1. APRESENTAÇÃO

Na semana de 28/12 a 03/01 houve precipitação nas bacias dos rios Grande, Paranaíba e São Francisco.

Na semana de 04/01 a 10/01 deve ocorrer precipitação nas bacias dos rios Paranaíba, São Francisco e Tocantins.

Os valores médios semanais do Custo Marginal de Operação – CMO dos subsistemas do SIN sofreram as seguintes alterações em relação à semana anterior:

- SE/CO: de R$ 15,44/MWh para R$ 40,52/MWh
- Sul: de R$ 15,44/MWh para R$ 40,52/MWh
- Nordeste: de R$ 15,44/MWh para R$ 40,52/MWh
- Norte: de R$ 15,44/MWh para R$ 40,52/MWh

Desde o dia 01/01/2020, o despacho por ordem de mérito é indicado diariamente pelos resultados do modelo DESSEM. Assim, o despacho por ordem de mérito semanal, conforme publicado nesse documento, tem caráter apenas informativo. Da mesma forma, desde o dia 01/01/2021, a formação de preço deixou o formato semanal/patamar de carga e passou a ser horário, de acordo também com os resultados do modelo DESSEM.

2. NOTÍCIAS

Nos dias 30 e 31 de janeiro será realizada a reunião de elaboração do PMO de Fevereiro de 2025, com transmissão ao vivo através do site do ONS.

3. INFORMAÇÕES CONJUNTURAIS PARA ELABORAÇÃO DO PMO

3.1. Informações Hidrometeorológicas

3.1.1. Condições antecedentes

A configuração da Zona de Convergência do Atlântico Sul (ZCAS) no início da semana favoreceu a ocorrência de precipitação nas bacias localizadas nas regiões Sudeste, Centro-Oeste e Norte, sendo que os maiores totais de precipitação ocorreram nas bacias dos rios Grande, Paranaíba e São Francisco, com valores entre a média e acima da média. No final da semana uma frente fria avançou pelo litoral da Região Sul ocasionando totais de precipitação abaixo da média nas bacias localizadas nessa Região (Figura 1).

O conteúdo desta publicação foi produzido pelo ONS com base em dados e informações de conhecimento público. É de responsabilidade exclusiva dos agentes e demais interessados a obtenção de outros dados e informações, a realização de análises, estudos e avaliações para fins de tomada de decisões, definição de estratégias de atuação, assunção de compromissos e obrigações e quaisquer outras finalidades, em qualquer tempo e sob qualquer condição. É proibida a reprodução ou utilização total ou parcial do presente sem a identificação da fonte.

Figura 1 - Precipitação observada (mm) no período de 28/12/2024 a 02/01/2025

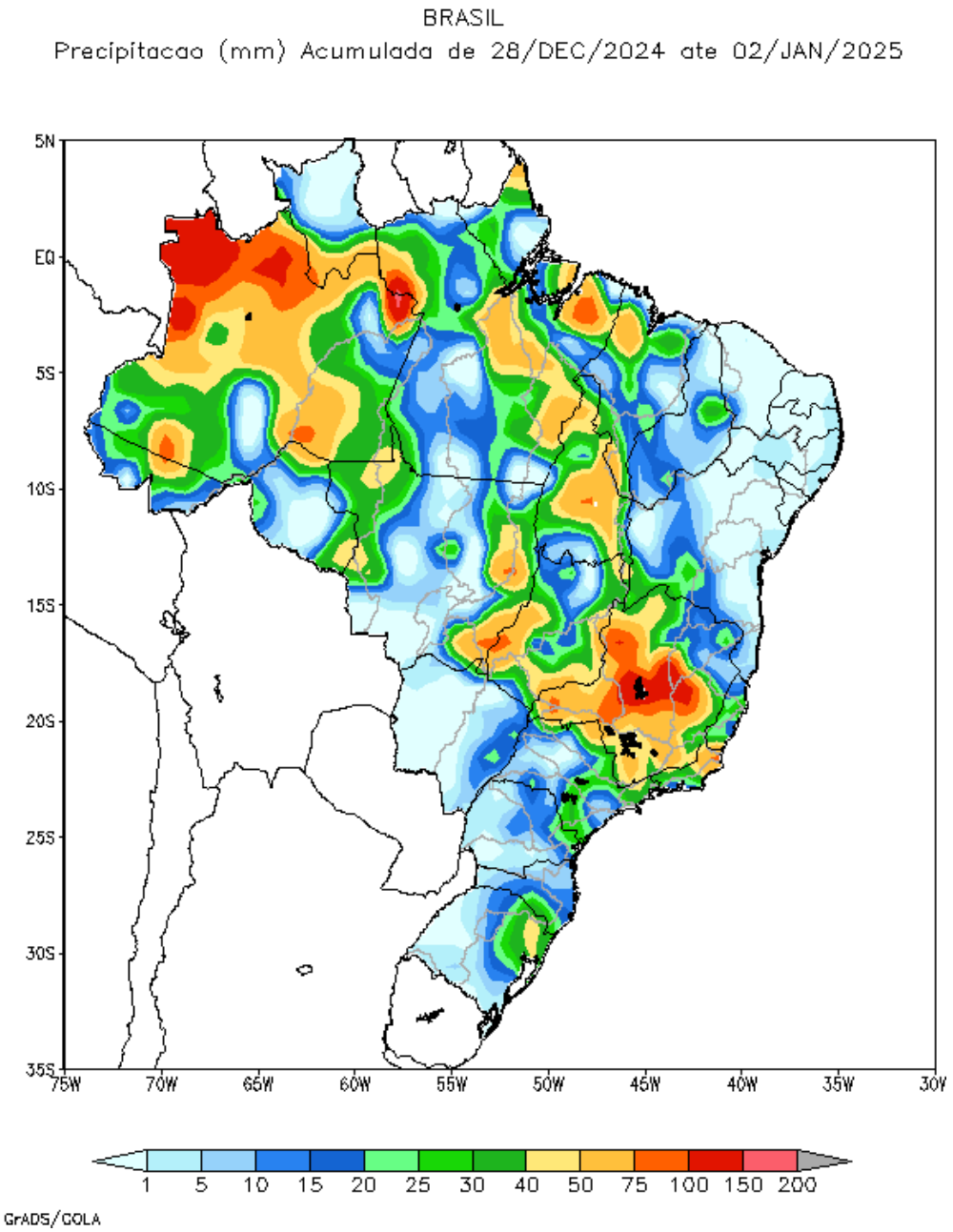

A **Tabela 1** apresenta as energias naturais afluentes das semanas recentes. São apresentados os valores verificados na semana 21/12/2024 a 27/12/2024 e os estimados para fechamento da semana de 28/12/2024 a 03/01/2025.

Tabela 1 – Tendência hidrológica da ENA da Revisão 1 de Janeiro/2025

Revisão 1 do PMO de Janeiro/2025 - ENAs				
Subsistema	21/12 a 27/12/2024		28/12 a 03/01/2025	
	MWmed	%MLT	MWmed	%MLT
SE/CO	49.903	104	64.006	115
S	14.331	191	8.987	120
NE	4.651	48	6.019	53
N	7.066	85	8.910	77

O conteúdo desta publicação foi produzido pelo ONS com base em dados e informações de conhecimento público. É de responsabilidade exclusiva dos agentes e demais interessados a obtenção de outros dados e informações, a realização de análises, estudos e avaliações para fins de tomada de decisões, definição de estratégias de atuação, assunção de compromissos e obrigações e quaisquer outras finalidades, em qualquer tempo e sob qualquer condição. É proibida a reprodução ou utilização total ou parcial do presente sem a identificação da fonte.

3.1.2. Previsões - Próxima semana

O avanço de uma frente fria pelas Regiões Sul e Sudeste no início da semana e a atuação de áreas de instabilidade nas Regiões Sudeste, Centro-Oeste, Norte e Nordeste ocasionam precipitação nas principais bacias do SIN, com os maiores totais previstos para as bacias dos rios Paranaíba, São Francisco e Tocantins (Figura 2).

Figura 2 - Precipitação acumulada prevista pelo modelo ECMWF – 04 a 10/01/2025

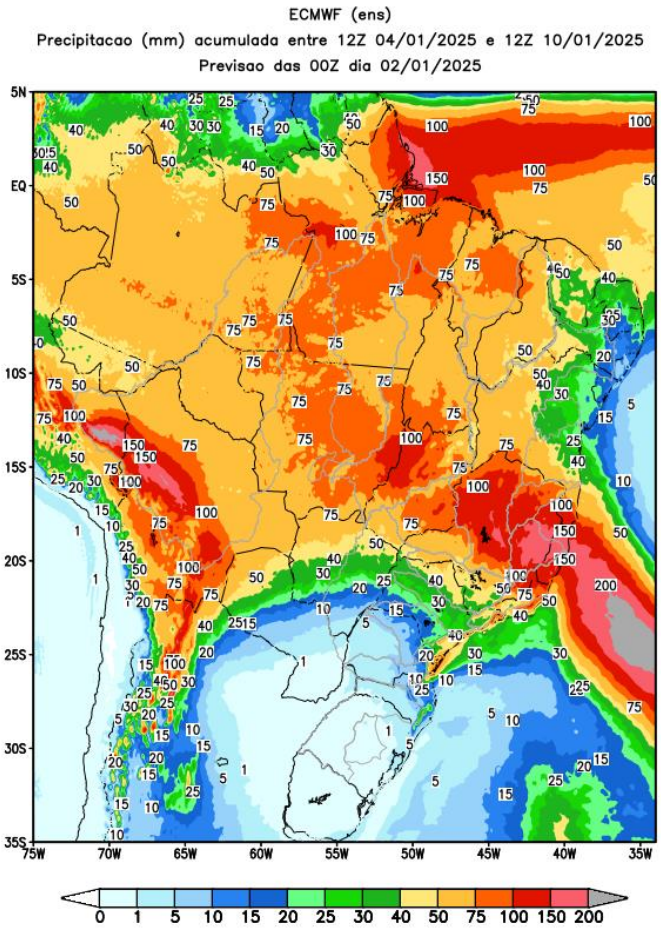

Em comparação com os valores estimados para a semana em curso, prevê-se para a próxima semana operativa ascensão nas afluências dos subsistemas Nordeste e Norte, recessão nas afluências do subsistema Sul e estabilidade nas afluências do subsistema Sudeste/Centro-Oeste. A previsão mensal para janeiro indica a ocorrência de afluências abaixo da média histórica para os subsistemas Sudeste/Centro-Oeste e Sul e acima da média histórica para os subsistemas Nordeste e Norte.

Tabela 2 – Previsão de ENAs da Revisão 1 de Janeiro/2025

Revisão 1 do PMO de Janeiro/2025 - ENAs previstas				
Subsistema	04/01 a 10/01/2025		Mês de janeiro	
	MWmed	%MLT	MWmed	%MLT
SE/CO	63.890	97	61.064	92
S	5.761	76	5.056	67
NE	9.545	71	14.759	109
N	12.551	79	19.284	121

O conteúdo desta publicação foi produzido pelo ONS com base em dados e informações de conhecimento público. É de responsabilidade exclusiva dos agentes e demais interessados a obtenção de outros dados e informações, a realização de análises, estudos e avaliações para fins de tomada de decisões, definição de estratégias de atuação, assunção de compromissos e obrigações e quaisquer outras finalidades, em qualquer tempo e sob qualquer condição. É proibida a reprodução ou utilização total ou parcial do presente sem a identificação da fonte.

As figuras a seguir ilustram as ENAs semanais verificadas e previstas para o PMO e para a Revisão 1 do PMO de Janeiro/2025.

Figura 3 - Energias Naturais Afluentes ao Subsistema Sudeste/Centro-Oeste do PMO e da Revisão 1 do PMO de Janeiro/2025

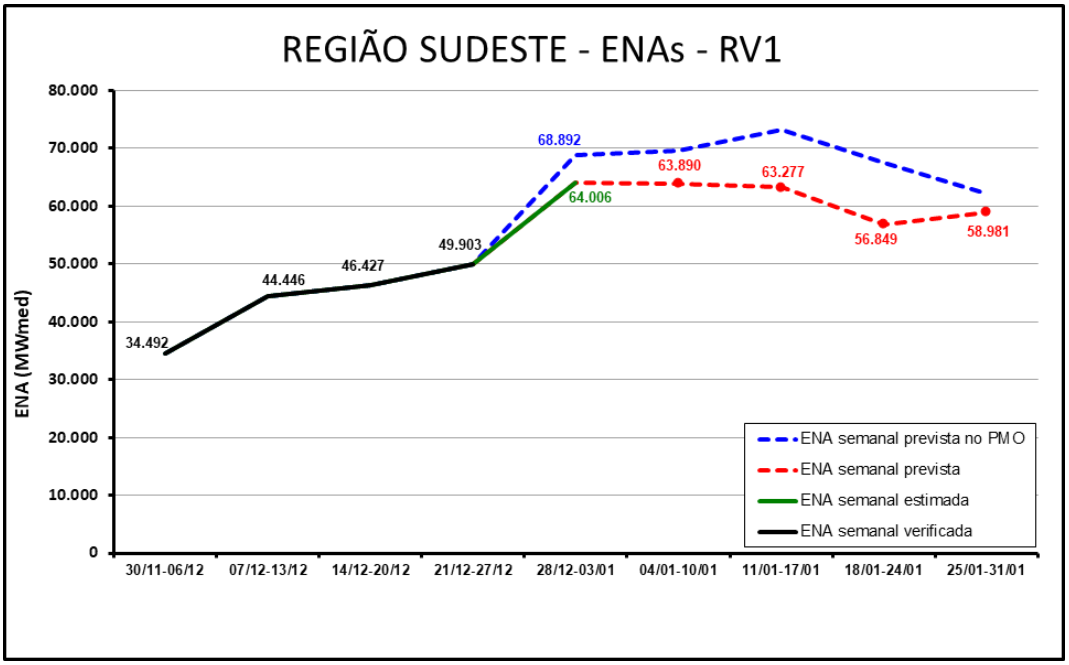

Figura 4 - Energias Naturais Afluentes ao Subsistema Sul do PMO e da Revisão 1 do PMO de Janeiro/2025

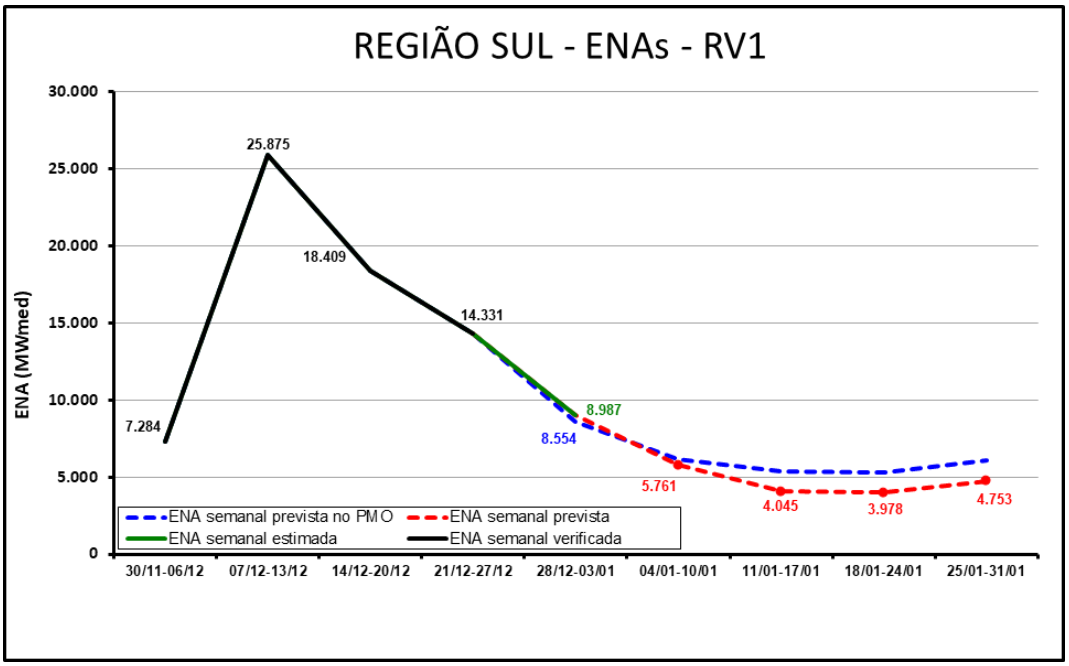

O conteúdo desta publicação foi produzido pelo ONS com base em dados e informações de conhecimento público. É de responsabilidade exclusiva dos agentes e demais interessados a obtenção de outros dados e informações, a realização de análises, estudos e avaliações para fins de tomada de decisões, definição de estratégias de atuação, assunção de compromissos e obrigações e quaisquer outras finalidades, em qualquer tempo e sob qualquer condição. É proibida a reprodução ou utilização total ou parcial do presente sem a identificação da fonte.

Figura 5 - Energias Naturais Afluentes ao Subsistema Nordeste do PMO e da Revisão 1 do PMO de Janeiro/2025

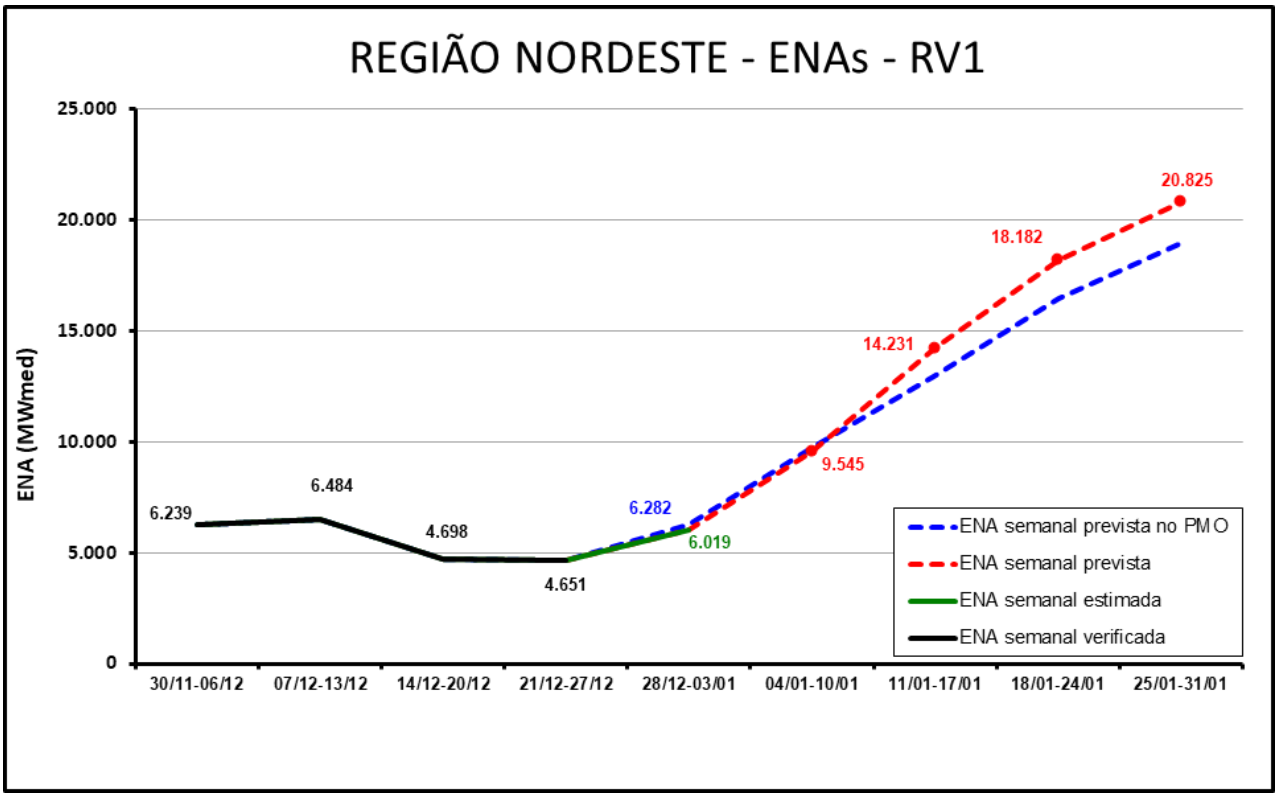

Figura 6 - Energias Naturais Afluentes ao Subsistema Norte do PMO e da Revisão 1 do PMO de Janeiro/2025

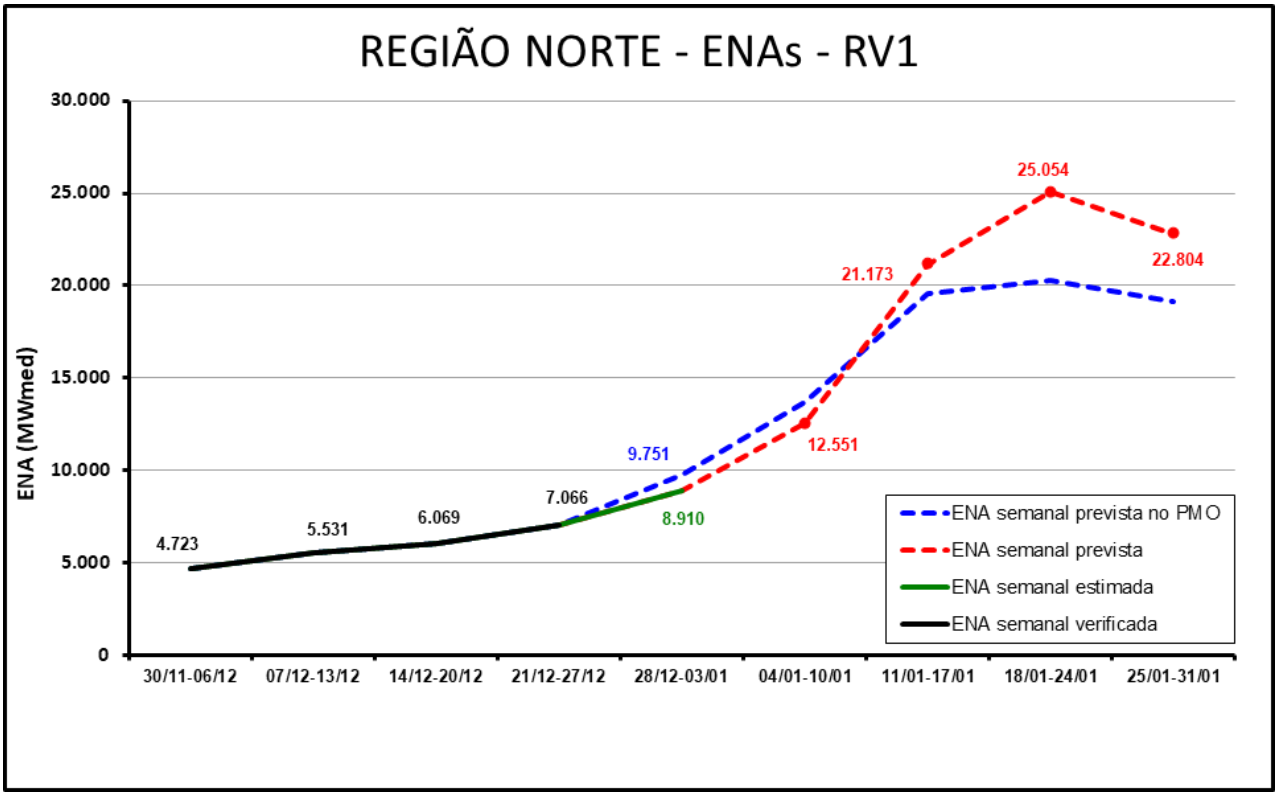

O conteúdo desta publicação foi produzido pelo ONS com base em dados e informações de conhecimento público. É de responsabilidade exclusiva dos agentes e demais interessados a obtenção de outros dados e informações, a realização de análises, estudos e avaliações para fins de tomada de decisões, definição de estratégias de atuação, assunção de compromissos e obrigações e quaisquer outras finalidades, em qualquer tempo e sob qualquer condição. É proibida a reprodução ou utilização total ou parcial do presente sem a identificação da fonte.

3.1.3. Cenários de ENAs para a Revisão 1 de Janeiro/2025

As figuras a seguir apresentam as características dos cenários de energias naturais afluentes gerados na Revisão 1 de Janeiro/2025, para acoplamento com a FCF do mês de fevereiro/2025. São mostradas, para os quatro subsistemas, as amplitudes e as Funções de Distribuição Acumulada dos cenários de ENA, comparativamente com os valores considerados para o PMO de Janeiro/2025.

Figura 7 - Amplitude dos Cenários de ENA para o Subsistema Sudeste/Centro-Oeste, em %MLT, para a Revisão 1 de Janeiro/2025

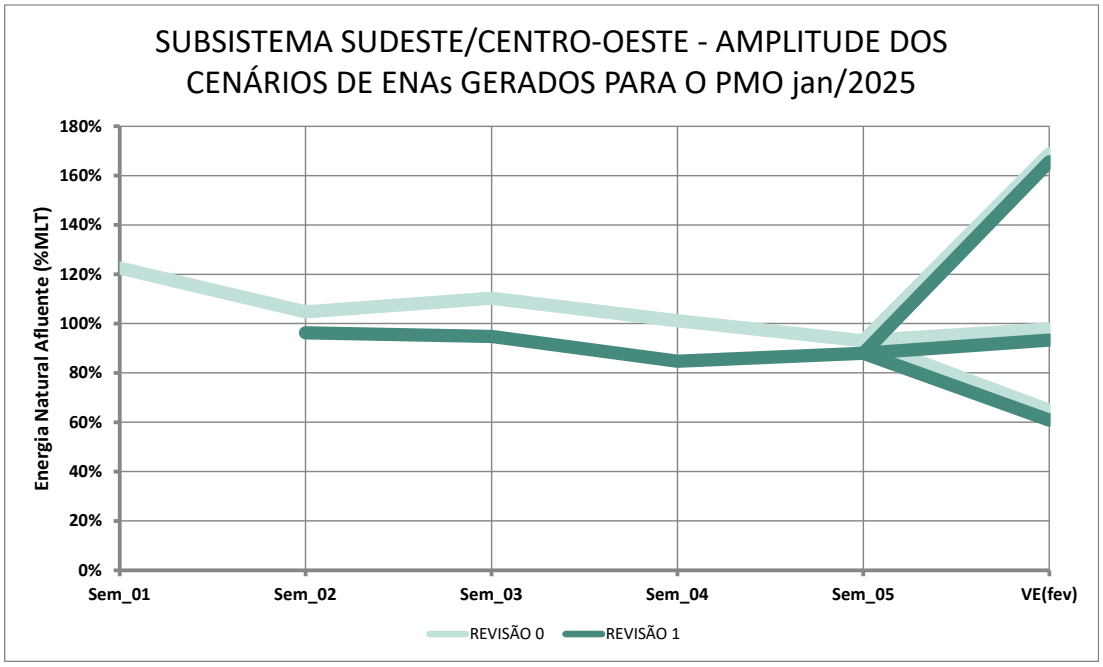

Figura 8 - Função de Distribuição Acumulada dos Cenários para o Subsistema Sudeste/Centro-Oeste para a Revisão 1 de Janeiro/2025

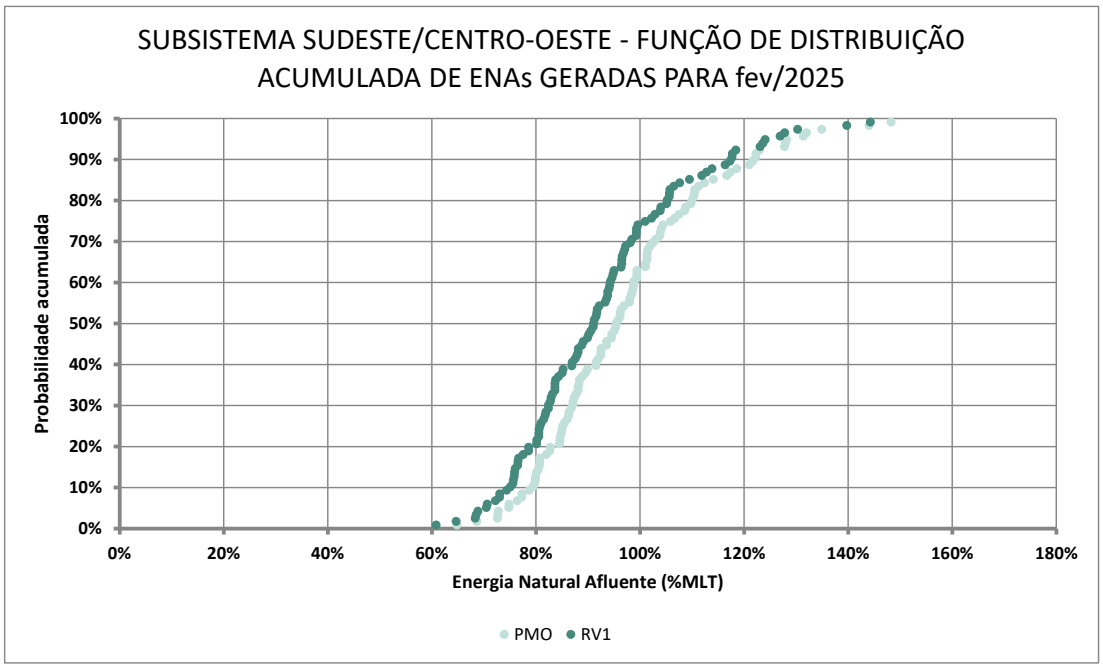

O conteúdo desta publicação foi produzido pelo ONS com base em dados e informações de conhecimento público. É de responsabilidade exclusiva dos agentes e demais interessados a obtenção de outros dados e informações, a realização de análises, estudos e avaliações para fins de tomada de decisões, definição de estratégias de atuação, assunção de compromissos e obrigações e quaisquer outras finalidades, em qualquer tempo e sob qualquer condição. É proibida a reprodução ou utilização total ou parcial do presente sem a identificação da fonte.

Figura 9 - Amplitude dos Cenários de ENA para o Subsistema Sul, em %MLT, para a Revisão 1 de Janeiro/2025

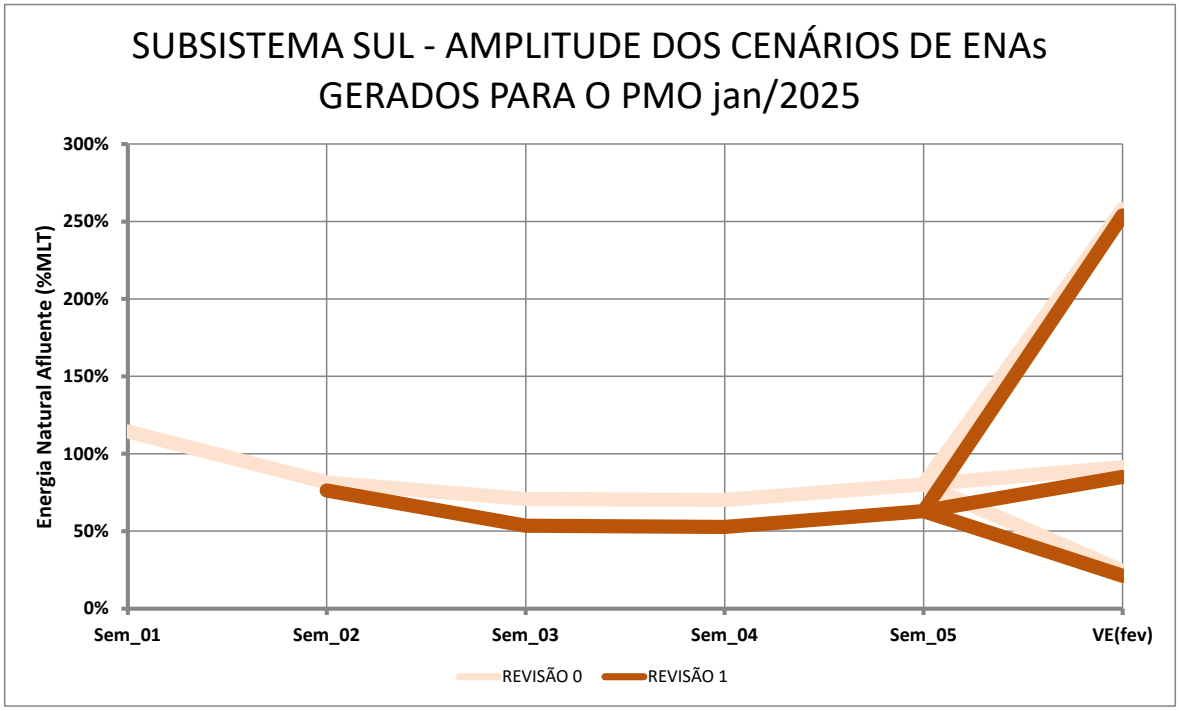

Figura 10 - Função de Distribuição Acumulada dos Cenários para o Subsistema Sul para a Revisão 1 de Janeiro/2025

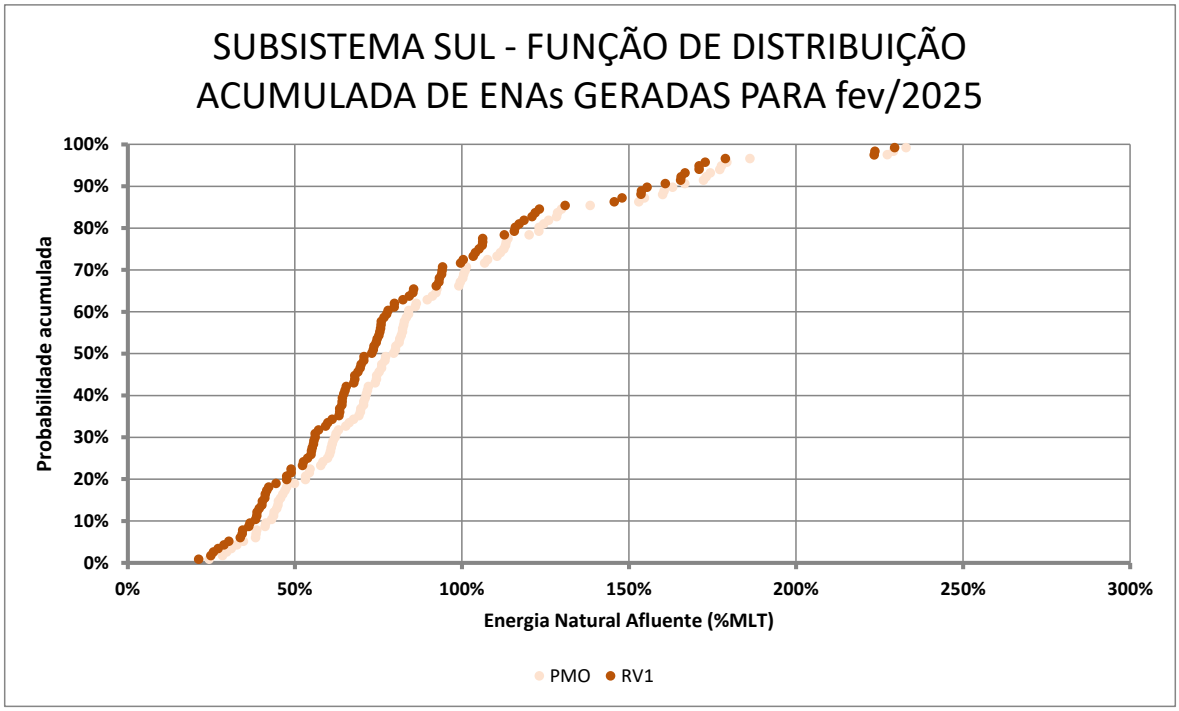

O conteúdo desta publicação foi produzido pelo ONS com base em dados e informações de conhecimento público. É de responsabilidade exclusiva dos agentes e demais interessados a obtenção de outros dados e informações, a realização de análises, estudos e avaliações para fins de tomada de decisões, definição de estratégias de atuação, assunção de compromissos e obrigações e quaisquer outras finalidades, em qualquer tempo e sob qualquer condição. É proibida a reprodução ou utilização total ou parcial do presente sem a identificação da fonte.

Figura 11 - Amplitude dos Cenários de ENA para o Subsistema Nordeste em %MLT, para a Revisão 1 de Janeiro/2025

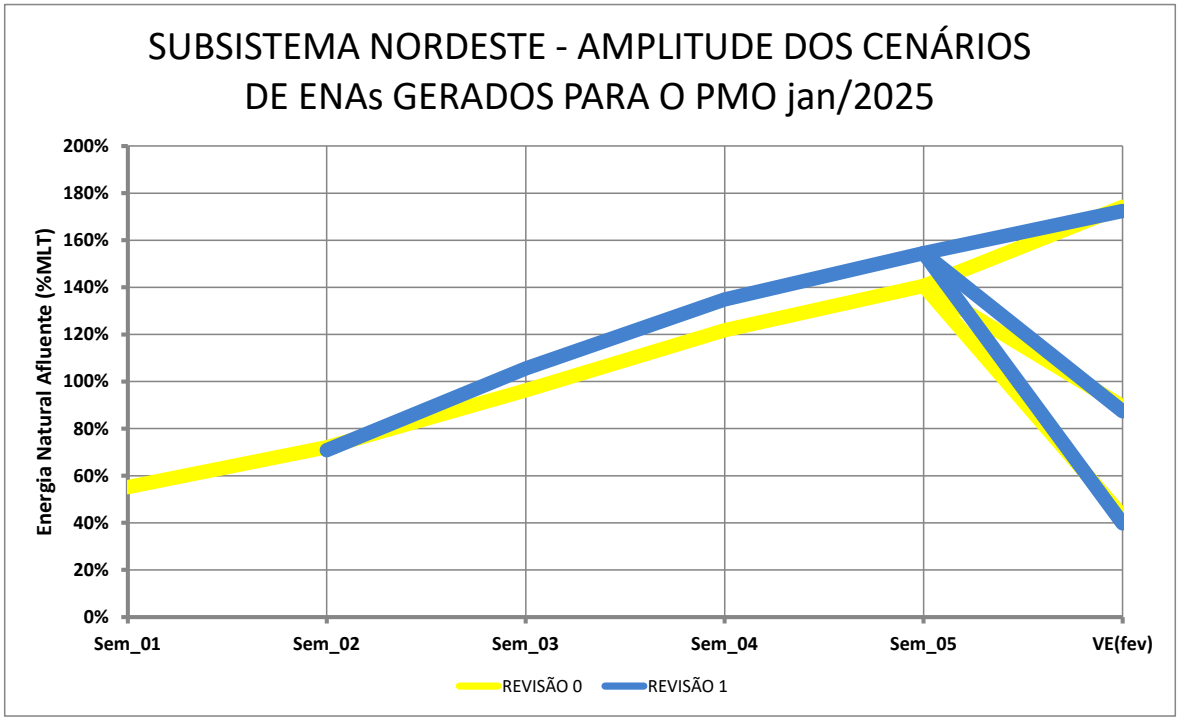

Figura 12 - Função de Distribuição Acumulada dos Cenários para o Subsistema Nordeste para a Revisão 1 de Janeiro/2025

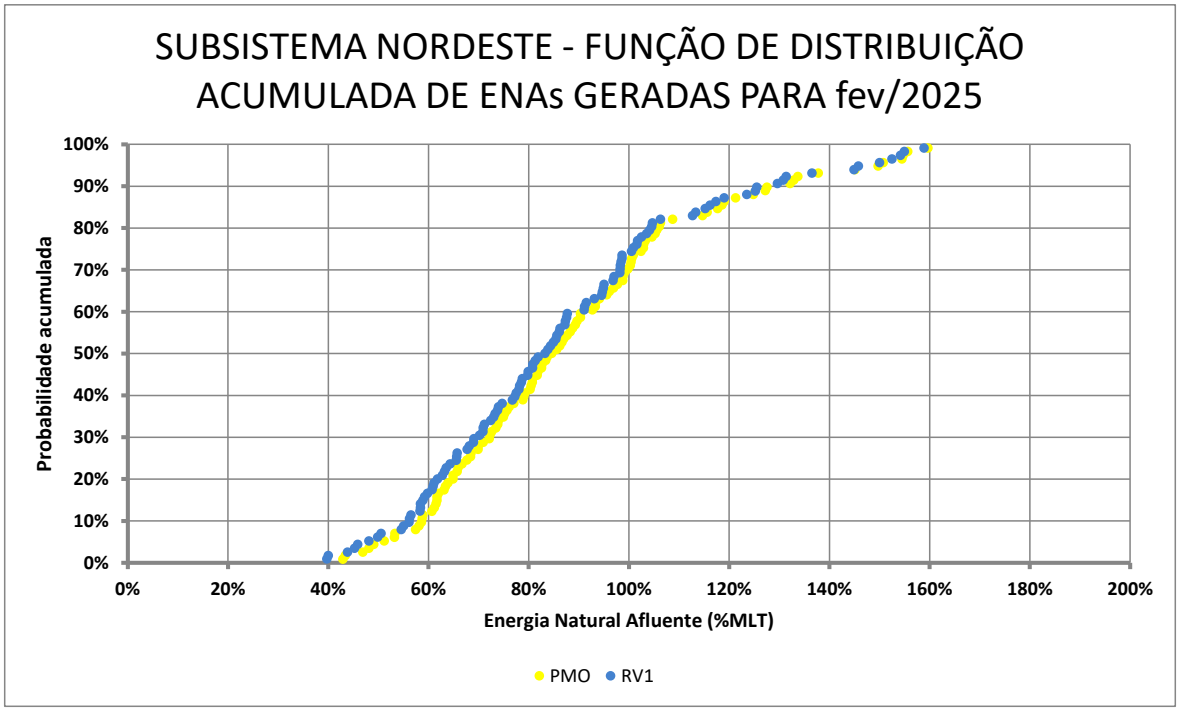

O conteúdo desta publicação foi produzido pelo ONS com base em dados e informações de conhecimento público. É de responsabilidade exclusiva dos agentes e demais interessados a obtenção de outros dados e informações, a realização de análises, estudos e avaliações para fins de tomada de decisões, definição de estratégias de atuação, assunção de compromissos e obrigações e quaisquer outras finalidades, em qualquer tempo e sob qualquer condição. É proibida a reprodução ou utilização total ou parcial do presente sem a identificação da fonte.

Figura 13 - Amplitude dos Cenários de ENA para o Subsistema Norte, em %MLT, para a Revisão 1 de Janeiro/2025

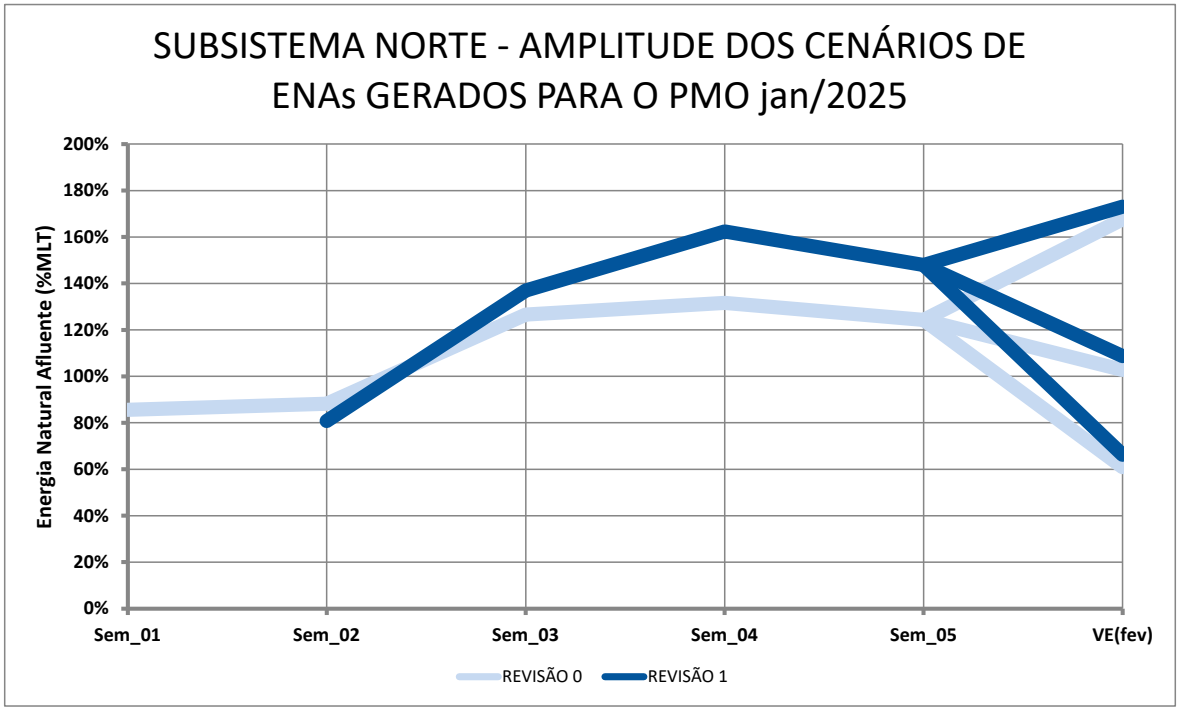

Figura 14 - Função de Distribuição Acumulada dos Cenários para o Subsistema Norte para a Revisão 1 de Janeiro/2025

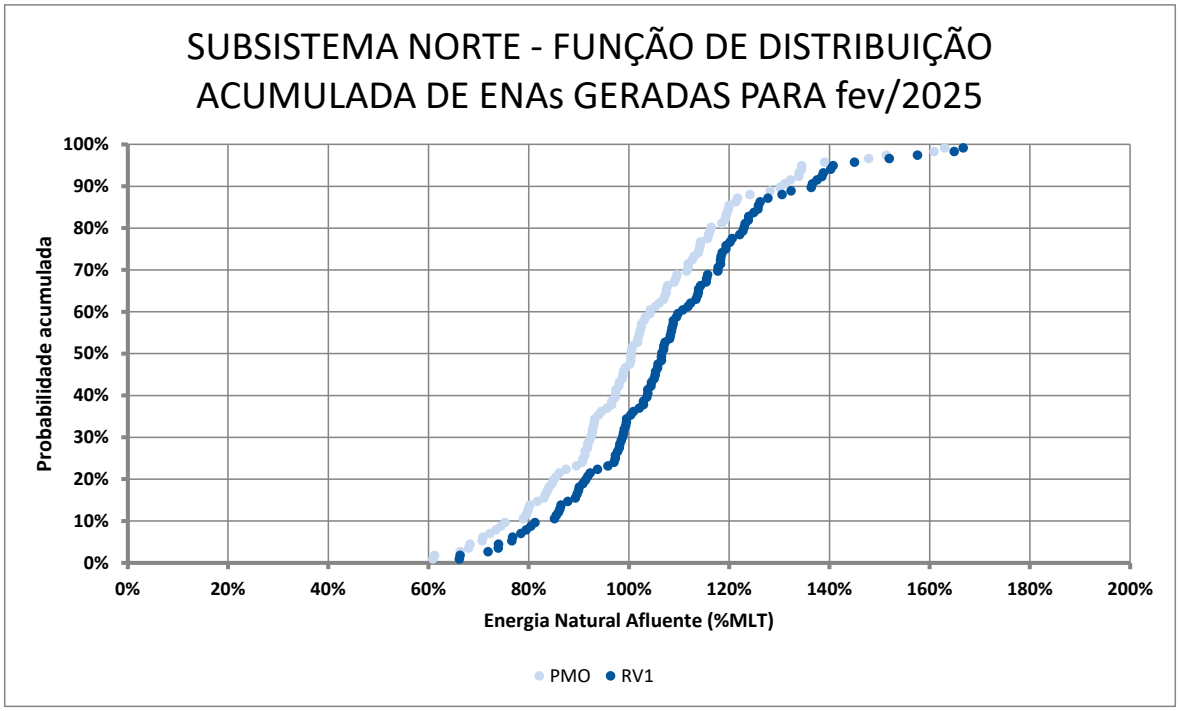

O conteúdo desta publicação foi produzido pelo ONS com base em dados e informações de conhecimento público. É de responsabilidade exclusiva dos agentes e demais interessados a obtenção de outros dados e informações, a realização de análises, estudos e avaliações para fins de tomada de decisões, definição de estratégias de atuação, assunção de compromissos e obrigações e quaisquer outras finalidades, em qualquer tempo e sob qualquer condição. É proibida a reprodução ou utilização total ou parcial do presente sem a identificação da fonte.

Os valores da MLT (Média de Longo Termo) das energias naturais afluentes para os meses de janeiro/2025 e fevereiro/2025 são apresentados na tabela a seguir.

Tabela 3 – MLT da ENA nos meses de janeiro/2025 e fevereiro/2025

MLT das ENAs (MWmed)		
Subsistema	janeiro	fevereiro
SE/CO	65.801	70.894
S	7.548	8.272
NE	13.479	14.238
N	15.832	22.811

3.2. Limites de Intercâmbio entre Subsistemas

Os limites elétricos de intercâmbio de energia entre subsistemas são de fundamental importância para o processo de otimização energética, sendo determinantes para a definição das políticas de operação e do CMO para cada subsistema. Estes limites são influenciados por intervenções na malha de transmissão, notadamente na primeira semana operativa. O diagrama a seguir ilustra os fluxos notáveis do SIN e os limites aplicados neste PMO.

Figura 15 – Interligações entre regiões

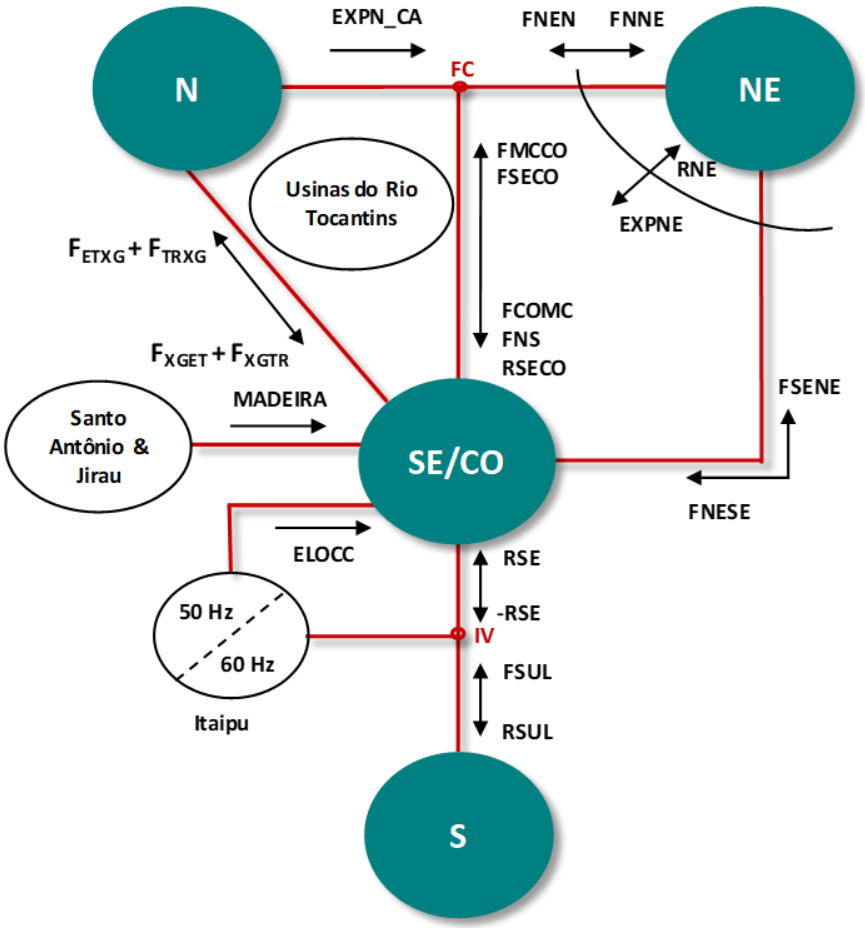

O conteúdo desta publicação foi produzido pelo ONS com base em dados e informações de conhecimento público. É de responsabilidade exclusiva dos agentes e demais interessados a obtenção de outros dados e informações, a realização de análises, estudos e avaliações para fins de tomada de decisões, definição de estratégias de atuação, assunção de compromissos e obrigações e quaisquer outras finalidades, em qualquer tempo e sob qualquer condição. É proibida a reprodução ou utilização total ou parcial do presente sem a identificação da fonte.

Tabela 4 – Limites considerados nesta semana operativa para intercâmbio de energia

Limites de Intercâmbio (MWmed)				
Fluxo	Patamar	04/01 a 10/01/2025		Demais Semanas
RNE	Pesada	11.000		11.000
	Média	11.000		11.000
	Leve	11.000		11.000
FNS	Pesada	3.150		3.150
	Média	**3.125**	(A)	3.150
	Leve	**2.895**		2.950
FNNE	Pesada	7.800		7.800
	Média	7.800		7.800
	Leve	7.800		7.800
EXPORT. NE	Pesada	13.800		13.800
	Média	13.800		13.800
	Leve	13.800		13.800
FMCCO	Pesada	5.000		5.000
	Média	5.000		5.000
	Leve	5.000		5.000
FSENE	Pesada	6.000		6.000
	Média	6.000		6.000
	Leve	6.000		6.000
FNS + FNESE	Pesada	7.650		7.650
	Média	6.286		6.286
	Leve	7.250		7.250
RSE	Pesada	9.800		9.800
	Média	9.800		9.800
	Leve	10.580		10.580
FORNEC. SUL	Pesada	7.000		7.000
	Média	7.000		7.000
	Leve	8.600		8.600

Limites de Intercâmbio (MWmed)				
Fluxo	Patamar	04/01 a 10/01/2025		Demais Semanas
RECEB. SUL	Pesada	9.380		9.380
	Média	7.480		7.480
	Leve	10.680		10.680
ELO CC 50 Hz	Pesada	**4.267**		6.264
	Média	**4.552**	(B)	6.264
	Leve	**5.277**		6.264
ITAIPU 60 Hz	Pesada	7.500		7.500
	Média	7.500		7.500
	Leve	7.500		7.500
EXP. N CA	Pesada	8.000		8.000
	Média	8.000		8.000
	Leve	8.000		8.000
FETXG + FTRXG	Pesada	4.200		4.200
	Média	4.200		4.200
	Leve	4.200		4.200
FXGET + FXGTR	Pesada	8.000		8.000
	Média	8.000		8.000
	Leve	8.000		8.000
FNESE	Pesada	5.500		5.500
	Média	**4.111**	(A)	4.136
	Leve	**5.445**		5.500
FNEN	Pesada	5.600		5.600
	Média	**5.498**	(A)	5.600
	Leve	**5.380**		5.600
Ger_MADEIRA	Pesada	**7.103**		7.418
	Média	**7.103**	(C)	7.418
	Leve	**7.103**		7.418

(A) SGI 76.943-24
(B) SGI 74.244-24
(C) MOP/ONS 408-S/2024

O conteúdo desta publicação foi produzido pelo ONS com base em dados e informações de conhecimento público. É de responsabilidade exclusiva dos agentes e demais interessados a obtenção de outros dados e informações, a realização de análises, estudos e avaliações para fins de tomada de decisões, definição de estratégias de atuação, assunção de compromissos e obrigações e quaisquer outras finalidades, em qualquer tempo e sob qualquer condição. É proibida a reprodução ou utilização total ou parcial do presente sem a identificação da fonte.

3.3. Previsão de carga

Em dezembro de 2024, o Índice de Confiança da Indústria (ICI) apresentou sua primeira alta (99,6 pontos) após três quedas consecutivas, no entanto, mantém a tendência de recuo nas médias móveis trimestrais. Tanto o indicador de situação atual quanto o Nível de Utilização da Capacidade Instalada (NUCI) mantém comportamento de retração, refletindo um ritmo mais fraco do setor no final do ano. Em contrapartida, a melhora nas expectativas futuras concentrou-se no setor de bens de consumo, ressaltando que o retorno da política monetária contracionista tende a conter a atividade econômica. De acordo com a FGV, fatores cambiais, além do cenário monetário e fiscais também trazem incertezas para o índice de expectativas futuras do comércio e serviços. A melhora do indicador de situação atual de ambos os setores, todavia reflete os bons resultados de emprego e renda observados ao longo do ano. No cômputo geral, o Indice de Confiança dos Serviços (ICS) recuou (94,3 pontos) enquanto o Índice de Confiança do Comércio avançou (93,3 pontos), e ambos mantiveram tendência altista nas médias móveis trimestrais.

Na Região Sudeste, a sinalização meteorológica indica ligeira diminuição das temperaturas em São Paulo no início e no final da próxima semana operativa, no entanto, espera-se estabilidade nas temperaturas médias. O Rio de Janeiro segue com comportamento análogo, resultando na primeira metade do período com temperaturas mais elevadas que a segunda metade. Além disso, nas capitais há previsão de precipitação ao longo de toda semana operativa. Nas capitais da região Sul, para a próxima semana operativa, a expectativa é de estabilidade das temperaturas médias em Porto Alegre e declínio em Florianópolis e Curitiba quando comparado com a semana em curso, com manutenção dos atuais totais de precipitação em todas as capitais.

Para as capitais das regiões Nordeste e Norte, espera-se estabilidade nas temperaturas médias. Tem-se indicação de precipitação em Manaus, Belém, Salvador, Recife, Fortaleza, São Luis e Belém, resultando em maiores totais de precipitação nas três últimas capitais mencionadas.

De uma forma geral, as premissas mencionadas acima impulsionaram somente o ajuste das previsões de carga do subsistema Sul na segunda semana operativa do mês e manutenção das previsões nos demais subsistemas em relação àquelas consideradas no estudo passado.

Com isso, as previsões de carga consolidadas para o mês de janeiro sinalizam acréscimo de 2,6% no subsistema Sudeste/Centro-Oeste, de 3,9% no subsistema Sul, 3,1% no subsistema Nordeste e 10,2% no subsistema Norte.

Tabela 5 – Evolução da carga do PMO de Janeiro de 2025

Subsistema	CARGA SEMANAL (MWmed)					CARGA MENSAL (MWmed)	
	1ª Sem	2ª Sem	3ª Sem	4ª Sem	5ª Sem	jan/25	Var. (%) jan/25 -> jan/24
SE/CO	40.611	44.907	47.499	47.730	48.102	46.435	2,6%
Sul	12.594	13.786	14.685	14.877	14.953	14.383	3,9%
Nordeste	13.361	13.727	13.708	13.750	13.738	13.695	3,1%
Norte	7.571	7.981	8.020	8.029	8.065	7.980	10,2%
SIN	**74.137**	**80.401**	**83.911**	**84.386**	**84.858**	**82.493**	**3,6%**

O conteúdo desta publicação foi produzido pelo ONS com base em dados e informações de conhecimento público. É de responsabilidade exclusiva dos agentes e demais interessados a obtenção de outros dados e informações, a realização de análises, estudos e avaliações para fins de tomada de decisões, definição de estratégias de atuação, assunção de compromissos e obrigações e quaisquer outras finalidades, em qualquer tempo e sob qualquer condição. É proibida a reprodução ou utilização total ou parcial do presente sem a identificação da fonte.

3.4. Potência Hidráulica Total Disponível no SIN

O gráfico a seguir mostra a disponibilidade hidráulica total do SIN, para este mês, de acordo com o cronograma de manutenção informado pelos agentes para esta revisão.

Figura 16 – Potência hidráulica disponível no SIN

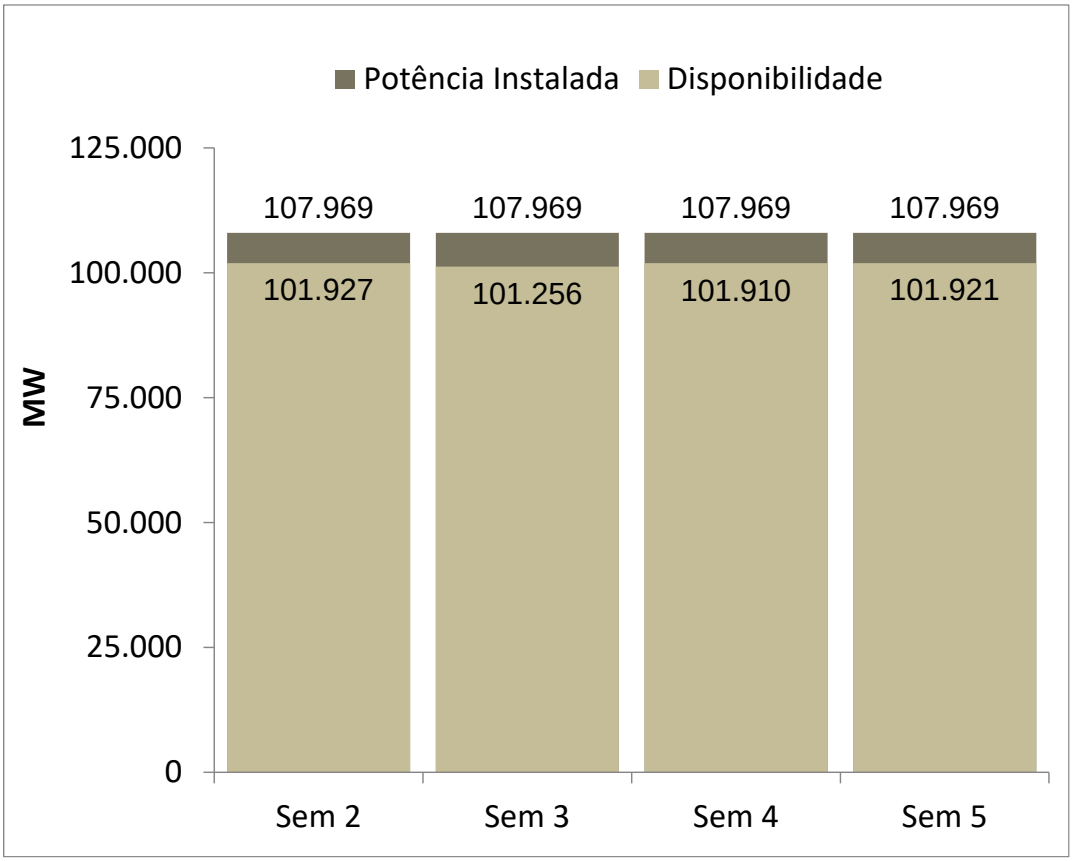

3.5. Armazenamentos Iniciais por Subsistema

Tabela 6 – Armazenamentos iniciais, por subsistema, considerados para esta semana operativa

Armazenamento (%EARmáx) - 0:00 h do dia 04/01/2025		
Subsistema	**Nível previsto na Revisão 0 do PMO Jan/2025**	**Partida informada pelos Agentes para a Revisão 1 do PMO Jan/2025**
SE/CO	51,7	52,5
S	81,3	79,4
NE	50,4	51,0
N	52,6	54,1

A primeira coluna da tabela acima corresponde ao armazenamento previsto na Revisão 0 do PMO de Janeiro de 2025, para a 0:00 h do dia 04/01/2025. A segunda coluna apresenta os armazenamentos obtidos a partir dos níveis de partida informados pelos Agentes de Geração para seus aproveitamentos com reservatórios.

O conteúdo desta publicação foi produzido pelo ONS com base em dados e informações de conhecimento público. É de responsabilidade exclusiva dos agentes e demais interessados a obtenção de outros dados e informações, a realização de análises, estudos e avaliações para fins de tomada de decisões, definição de estratégias de atuação, assunção de compromissos e obrigações e quaisquer outras finalidades, em qualquer tempo e sob qualquer condição. É proibida a reprodução ou utilização total ou parcial do presente sem a identificação da fonte.

4. PRINCIPAIS RESULTADOS

4.1. Política de Operação Energética

Para esta semana operativa, está prevista a seguinte política de intercâmbio de energia entre regiões:

Região SE/CO:

- Utilização dos recursos das bacias dos rios Grande, Paranaíba e Paraná, conforme necessidade de alocação na carga média e pesada e controle de nível atendendo as resoluções da ANA.

Região Sul:

- Exploração mais acentuada da geração hidráulica da bacia do Iguaçu e usinas do rio Canoas em função das condições hidrológicas;

- Exploração da bacia do rio Jacuí e demais usinas do rio Uruguai conforme necessidade para atendimento da carga.

Região NE:

- Atendimento as restrições da curva de segurança da bacia do Rio São Francisco.

Região Norte:

- Exploração da geração das usinas da bacia do rio Tocantins e Xingu para atendimento à ponta de carga;

- Operação minimizada na UHE Balbina e Araguari do Norte.

4.2. Custo Marginal de Operação – CMO

A figura a seguir apresenta os Custos Marginais de Operação, em valores médios semanais, para as semanas operativas deste mês.

Figura 17 – CMO em valores médios

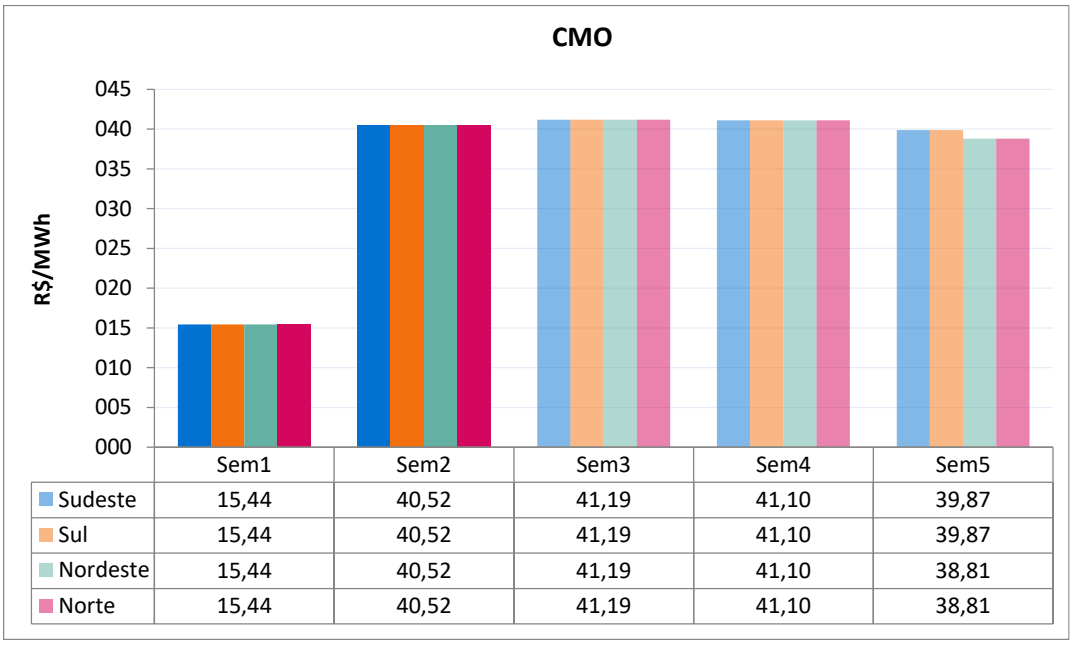

	Sem1	Sem2	Sem3	Sem4	Sem5
Sudeste	15,44	40,52	41,19	41,10	39,87
Sul	15,44	40,52	41,19	41,10	39,87
Nordeste	15,44	40,52	41,19	41,10	38,81
Norte	15,44	40,52	41,19	41,10	38,81

O conteúdo desta publicação foi produzido pelo ONS com base em dados e informações de conhecimento público. É de responsabilidade exclusiva dos agentes e demais interessados a obtenção de outros dados e informações, a realização de análises, estudos e avaliações para fins de tomada de decisões, definição de estratégias de atuação, assunção de compromissos e obrigações e quaisquer outras finalidades, em qualquer tempo e sob qualquer condição. É proibida a reprodução ou utilização total ou parcial do presente sem a identificação da fonte.

A tabela a seguir apresenta o custo marginal de operação, por subsistema e patamar de carga, para a próxima semana operativa.

Tabela 7 – CMO para esta semana operativa

Patamares de Carga	CMO (R$/MWh)			
	SE/CO	S	NE	N
Pesada	40,96	40,96	40,96	40,96
Média	40,58	40,58	40,58	40,58
Leve	40,22	40,22	40,22	40,22
Média Semanal	40,52	40,52	40,52	40,52

4.1 Energia Armazenada

O processo de otimização realizado pelo programa DECOMP indicou os armazenamentos mostrados na figura a seguir para as próximas semanas operativas do mês de janeiro/2025.

Figura 18 – Energias Armazenadas nas semanas operativas do mês de janeiro/2025.

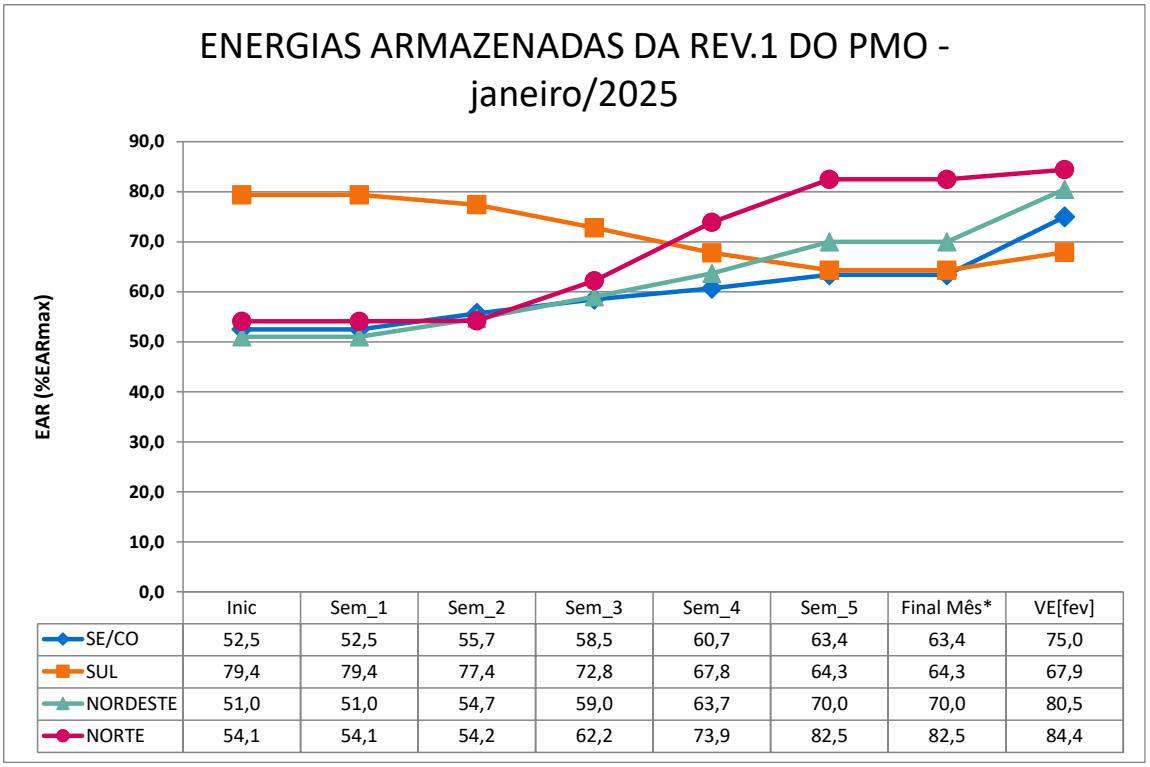

Os armazenamentos da figura anterior estão expressos em percentual da Energia Armazenável Máxima de cada subsistema, que são mostradas na tabela a seguir.

Tabela 8 – Energia Armazenável Máxima por subsistema no PMO de Janeiro/2025.

ENERGIA ARMAZENÁVEL MÁXIMA (MWmed)		
Subsistema	janeiro	fevereiro
SE/CO	205.569	205.569
S	20.458	20.458
NE	51.718	51.718
N	15.798	15.820

O conteúdo desta publicação foi produzido pelo ONS com base em dados e informações de conhecimento público. É de responsabilidade exclusiva dos agentes e demais interessados a obtenção de outros dados e informações, a realização de análises, estudos e avaliações para fins de tomada de decisões, definição de estratégias de atuação, assunção de compromissos e obrigações e quaisquer outras finalidades, em qualquer tempo e sob qualquer condição. É proibida a reprodução ou utilização total ou parcial do presente sem a identificação da fonte.

5. GERAÇÃO TÉRMICA

A Figura 19 apresenta, para cada subsistema do SIN, o despacho térmico por modalidade indicado pelo Decomp para esta semana operativa.

Figura 19 – Geração térmica para a próxima semana operativa

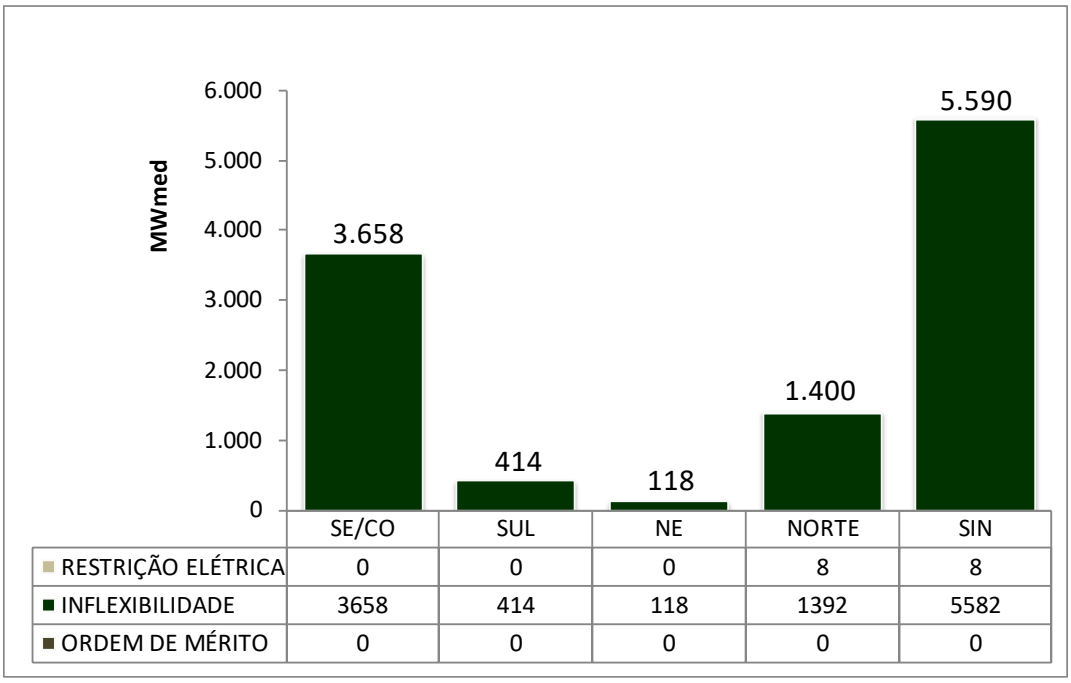

Na tabela abaixo segue a Indicação de despacho antecipado por ordem de mérito de custo para a semana de 08/03/2025 a 14/03/2025.

Tabela 9 – UTEs com contrato de combustível GNL

UTE			Benefício (R$/MWh)		
Nome	Cod	CVU (R$/MWh)	Carga Pesada	Carga Média	Carga Leve
SANTA CRUZ	86	251,80	36,11 (2)	35,39 (2)	34,64 (2)
LUIZORMELO	15	382,68	36,11 (2)	35,39 (2)	34,64 (2)
PSERGIPE I	224	365,30	12,87 (2)	12,61 (2)	12,55 (2)

(1) Comandado o despacho antecipado por ordem de mérito de custo nesse patamar
(2) NÃO foi comandado o despacho antecipado por ordem de mérito de custo nesse patamar

Assim sendo, não há previsão de despacho antecipado por ordem de mérito de custo para as UTE Santa Cruz, Luiz O. R. Melo e Porto Sergipe I, para a semana de 08/03/2025 a 14/03/2025.

O conteúdo desta publicação foi produzido pelo ONS com base em dados e informações de conhecimento público. É de responsabilidade exclusiva dos agentes e demais interessados a obtenção de outros dados e informações, a realização de análises, estudos e avaliações para fins de tomada de decisões, definição de estratégias de atuação, assunção de compromissos e obrigações e quaisquer outras finalidades, em qualquer tempo e sob qualquer condição. É proibida a reprodução ou utilização total ou parcial do presente sem a identificação da fonte.

6. RESUMO DOS RESULTADOS DO PMO

As figuras a seguir apresentam um resumo dos resultados da Revisão 1 de Janeiro/2025, com informações da Energia Natural Afluente (ENA), da Energia Armazenada (EAR) e do Custo Marginal de Operação (CMO) nos subsistemas do Sistema Interligado Nacional (SIN). São apresentados os valores semanais observados e previstos e o valor esperado dos cenários gerados para o mês de fevereiro/2025.

Figura 20 – Resumo de janeiro/2025 para o Subsistema Sudeste/Centro-Oeste

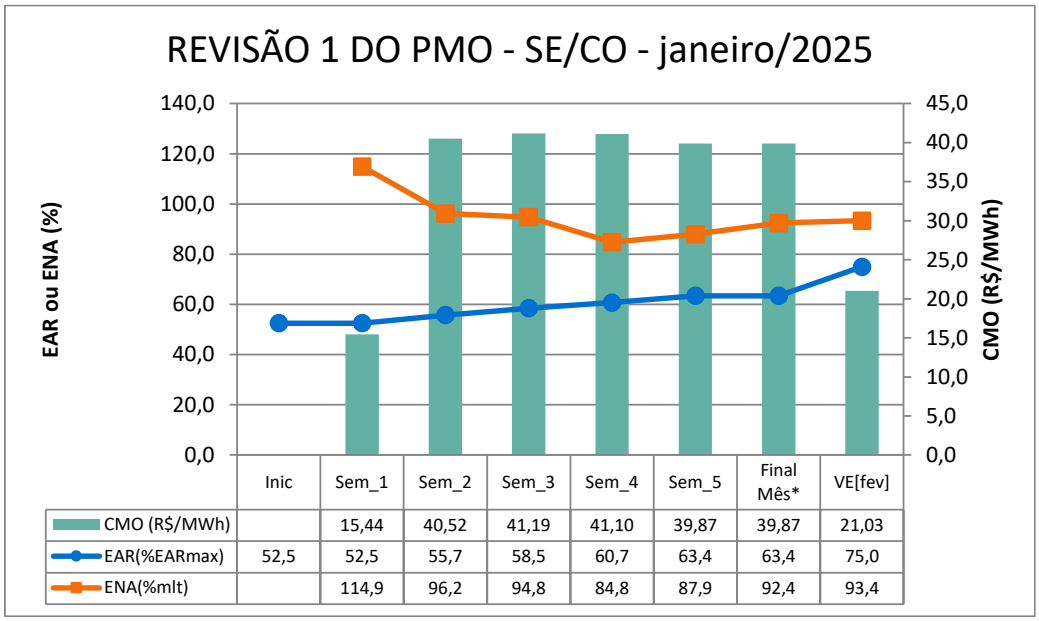

	Inic	Sem_1	Sem_2	Sem_3	Sem_4	Sem_5	Final Mês*	VE[fev]
CMO (R$/MWh)		15,44	40,52	41,19	41,10	39,87	39,87	21,03
EAR(%EARmax)	52,5	52,5	55,7	58,5	60,7	63,4	63,4	75,0
ENA(%mlt)		114,9	96,2	94,8	84,8	87,9	92,4	93,4

Figura 21 – Resumo de janeiro/2025 para o Subsistema Sul

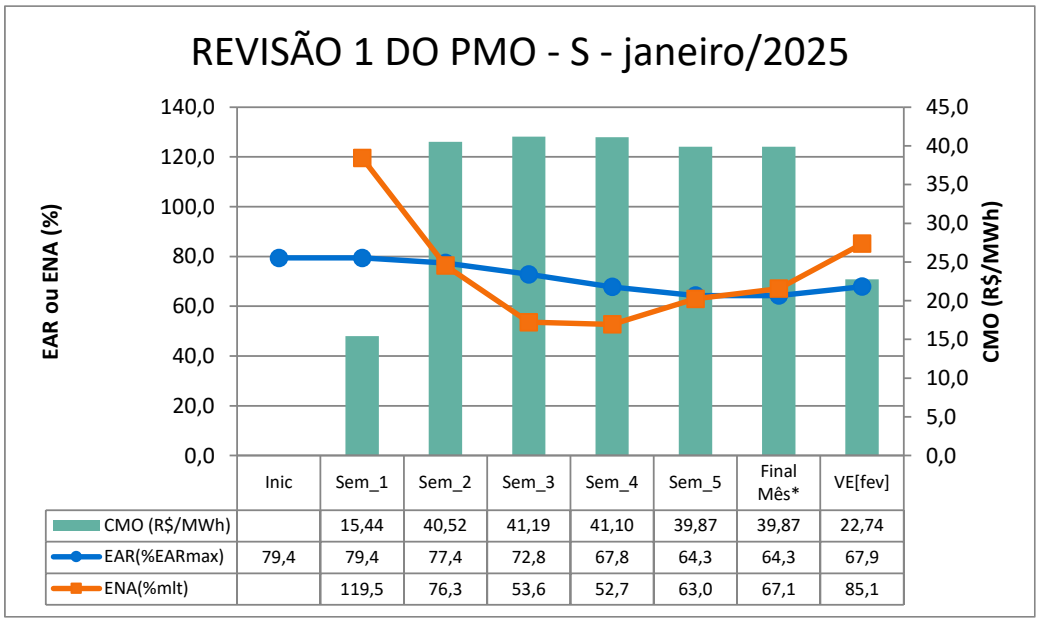

	Inic	Sem_1	Sem_2	Sem_3	Sem_4	Sem_5	Final Mês*	VE[fev]
CMO (R$/MWh)		15,44	40,52	41,19	41,10	39,87	39,87	22,74
EAR(%EARmax)	79,4	79,4	77,4	72,8	67,8	64,3	64,3	67,9
ENA(%mlt)		119,5	76,3	53,6	52,7	63,0	67,1	85,1

O conteúdo desta publicação foi produzido pelo ONS com base em dados e informações de conhecimento público. É de responsabilidade exclusiva dos agentes e demais interessados a obtenção de outros dados e informações, a realização de análises, estudos e avaliações para fins de tomada de decisões, definição de estratégias de atuação, assunção de compromissos e obrigações e quaisquer outras finalidades, em qualquer tempo e sob qualquer condição. É proibida a reprodução ou utilização total ou parcial do presente sem a identificação da fonte.

Figura 22 – Resumo de janeiro/2025 para o Subsistema Nordeste

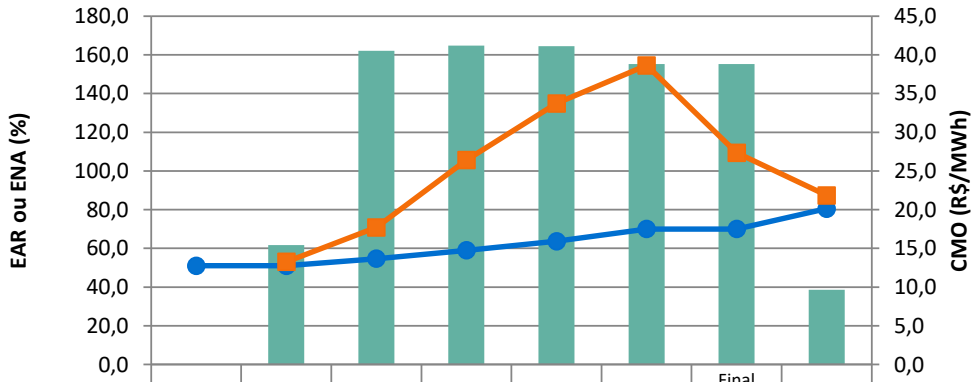

	Inic	Sem_1	Sem_2	Sem_3	Sem_4	Sem_5	Final Mês*	VE[fev]
CMO (R$/MWh)		15,44	40,52	41,19	41,10	38,81	38,81	9,66
EAR(%EARmax)	51,0	51,0	54,7	59,0	63,7	70,0	70,0	80,5
ENA(%mlt)		53,0	70,8	105,6	134,9	154,5	109,4	87,3

Figura 23 – Resumo de janeiro/2025 para o Subsistema Norte

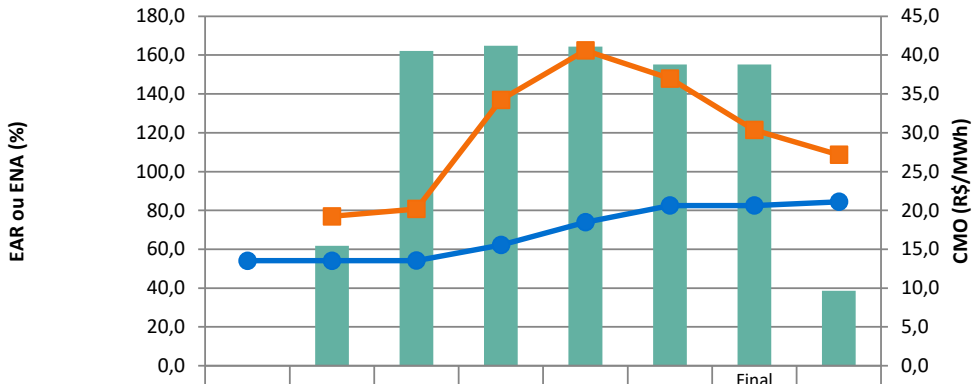

	Inic	Sem_1	Sem_2	Sem_3	Sem_4	Sem_5	Final Mês*	VE[fev]
CMO (R$/MWh)		15,44	40,52	41,19	41,10	38,81	38,81	9,66
EAR(%EARmax)	54,1	54,1	54,2	62,2	73,9	82,5	82,5	84,4
ENA(%mlt)		77,0	80,7	136,9	162,4	147,9	121,4	108,7

O conteúdo desta publicação foi produzido pelo ONS com base em dados e informações de conhecimento público. É de responsabilidade exclusiva dos agentes e demais interessados a obtenção de outros dados e informações, a realização de análises, estudos e avaliações para fins de tomada de decisões, definição de estratégias de atuação, assunção de compromissos e obrigações e quaisquer outras finalidades, em qualquer tempo e sob qualquer condição. É proibida a reprodução ou utilização total ou parcial do presente sem a identificação da fonte.

7. ARMAZENAMENTOS OPERATIVOS

Para uma melhor avaliação de diversos cenários hidrometeorológicos, notadamente, aqueles de curto prazo e suas influências nas previsões de vazões nos subsistemas, os resultados desta revisão do PMO contemplam cenários de afluências visando melhor representar a ocorrência de precipitação e, consequentemente, seus efeitos sobre as afluências e armazenamentos.

Apresentamos a seguir as correspondentes energias naturais afluentes e os resultados obtidos com a aplicação do cenário de afluência utilizado no estudo.

Tabela 10 – Previsão de ENA do caso de valor esperado das previsões de afluência

Subsistema	ENERGIAS NATURAIS AFLUENTES			
	Previsão Semanal		Previsão Mensal	
	(MWmed)	%MLT	(MWmed)	%MLT
SE/CO	63.890	**97**	61.064	**92**
Sul	5.761	**76**	5.056	**67**
Nordeste	9.545	**71**	14.759	**109**
Norte	12.551	**79**	19.284	**121**

Tabela 11 – Previsão de %EARmáx para o final do mês

Subsistema	% EARmáx 03/01	% EARmáx - 31/01
	NÍVEL INICIAL	NÍVEL PMO
SE/CO	**52,5**	**63,4**
Sul	**79,4**	**64,3**
Nordeste	**51,0**	**70,0**
Norte	**54,1**	**82,5**

O conteúdo desta publicação foi produzido pelo ONS com base em dados e informações de conhecimento público. É de responsabilidade exclusiva dos agentes e demais interessados a obtenção de outros dados e informações, a realização de análises, estudos e avaliações para fins de tomada de decisões, definição de estratégias de atuação, assunção de compromissos e obrigações e quaisquer outras finalidades, em qualquer tempo e sob qualquer condição. É proibida a reprodução ou utilização total ou parcial do presente sem a identificação da fonte.

8. RESERVATÓRIOS EQUIVALENTES DE ENERGIA

A seguir são apresentadas as previsões de Energia Natural Afluente para a próxima semana operativa e para o mês de janeiro, bem como as previsões de Energia Armazenada nos Reservatórios Equivalentes de Energia – REE, do desta revisão do PMO de Janeiro de 2025.

Tabela 12 – Previsão de ENA por REE

Valor Esperado das Energias Naturais Afluentes				
REE	Previsão Semanal		Previsão Mensal	
	04/01/2025 a 10/01/2025		jan-25	
	(MWmed)	%MLT	(MWmed)	%MLT
Sudeste	11.333	108	12.431	118
Madeira	4.854	60	7.058	87
Teles Pires	2.720	80	3.370	99
Itaipu	2.698	80	2.251	67
Paraná	39.832	108	33.292	90
Paranapanema	1.879	51	1.767	48
Sul	2.068	60	1.949	57
Iguaçu	3.693	90	3.107	75
Nordeste	9.545	71	14.759	109
Norte	7.908	83	13.027	136
Belo Monte	4.454	77	6.124	106
Manaus	421	83	600	118

Tabela 13 – Previsão de %EARmáx por REE

% Energia Armazenável Máxima		
REE	Previsão Semanal	Previsão Mensal
	10-jan	31-jan
	(%EARmáx)	(%EARmáx)
Sudeste	57,5	66,1
Madeira	18,8	30,2
Teles Pires	32,8	68,8
Itaipu	94,4	77,3
Paraná	54,4	62,8
Paranapanema	63,1	59,5
Sul	61,7	60,7
Iguaçu	92,8	67,8
Nordeste	54,7	70,0
Norte	57,0	87,0
Belo Monte	26,7	11,8
Manaus	1,7	0,0

O conteúdo desta publicação foi produzido pelo ONS com base em dados e informações de conhecimento público. É de responsabilidade exclusiva dos agentes e demais interessados a obtenção de outros dados e informações, a realização de análises, estudos e avaliações para fins de tomada de decisões, definição de estratégias de atuação, assunção de compromissos e obrigações e quaisquer outras finalidades, em qualquer tempo e sob qualquer condição. É proibida a reprodução ou utilização total ou parcial do presente sem a identificação da fonte.

9. DESPACHO TÉRMICO POR MODALIDADE, PATAMAR DE CARGA E USINA

Nas tabelas abaixo, a diferenciação entre geração por inflexibilidade e por ordem de mérito tem caráter informativo, com o objetivo de detalhar a informação de inflexibilidade enviada pelos respectivos agentes para esta revisão do PMO. Ressalta-se que nas etapas de Programação Diária e Tempo Real, o montante despachado nas usinas termelétricas indicadas por ordem de mérito é plenamente intitulado como ordem de mérito.

Tabela 14 – Despachos de Geração Térmica

REGIÃO SUDESTE/CENTRO-OESTE																	
Térmicas Potência (MW)	Combustível	CVU	Inflexibilidade			Ordem de Mérito			Total Mérito e INFL.			Razão Elétrica			Total UTE		
			P	M	L	P	M	L	P	M	L	P	M	L	P	M	L
ATLAN_CSA (255)	Resíduos	0,00	148,0	148,0	148,0				148,0	148,0	148,0				148,0	148,0	148,0
DAIA (44)	Diesel	---															
TNORTE 2 (349)	Óleo	---															
VIANA (175)	Óleo	---															
W.ARJONA O (177)	Diesel	---															
XAVANTES (54)	Diesel	---															
ANGRA 2 (1350)	Nuclear	20,12	1350,0	1350,0	1350,0				1350,0	1350,0	1350,0				1350,0	1350,0	1350,0
ANGRA 1 (640)	Nuclear	31,17	640,0	640,0	640,0				640,0	640,0	640,0				640,0	640,0	640,0
O.PINTADA (50)	Biomassa	145,52															
UTE STA VI (41)	Biomassa	157,20															
M.AZUL (566)	Gás	162,17	498,0	498,0	498,0				498,0	498,0	498,0				498,0	498,0	498,0
BAIXADA FL (530)	Gás	247,89															
ATLANTICO (235)	Resíduos	250,89	218,7	218,7	218,7				218,7	218,7	218,7				218,7	218,7	218,7
SANTA CRUZ (500)	GNL	251,80															
ST.CRUZ 34 (436)	Óleo	310,41															
LUIZORMELO (204)	GNL	382,68															
PIRAT.12 O (200)	Gás	470,34															
UTE GNA I (1338)	Gás	482,60															
CUBATAO (216)	Gás	517,49	177,0	187,3	206,7				177,0	187,3	206,7				177,0	187,3	206,7
NORTEFLU (826)	Gás	930,80															
T.MACAE (929)	Gás	932,00															
IBIRITE (235)	Gás	957,97															
TERMORIO (989)	Gás	1040,38	280,0	280,0	280,0				280,0	280,0	280,0				280,0	280,0	280,0
KARKEY 013 (259)	Gás	1050,14	30,0	30,0	30,0				30,0	30,0	30,0				30,0	30,0	30,0
KARKEY 019 (116)	Gás	1050,14															
T.LAGOAS (350)	Gás	1145,68															
PORSUD II (78)	Gás	1221,04															
PORSUD I (116)	Gás	1223,52															
CUIABA CC (529)	Gás	1265,78															
J.FORA (87)	Gás	1384,75															
SEROPEDICA (360)	Gás	1401,33															
PALMEIR_GO (176)	Diesel	1436,85															
PAULINIA (16)	Gás	1504,38	15,7	15,7	15,7				15,7	15,7	15,7				15,7	15,7	15,7
LORM_PCS (36)	Gás	1541,06															
POVOACAO I (75)	Gás	1541,06															
VIANA I (37)	Gás	1541,06															
NPIRATINGA (572)	Gás	1673,38	285,0	285,0	285,0				285,0	285,0	285,0				285,0	285,0	285,0
W.ARJONA (177)	Gás	1711,18															
TOTAL SE/CO (12320)			3642,4	3652,7	3672,1	0,0	0,0	0,0	3642,4	3652,7	3672,1	0,0	0,0	0,0	3642,4	3652,7	3672,1

REGIÃO SUL																	
Térmicas Potência (MW)	Combustível	CVU	Inflexibilidade			Ordem de Mérito			Total Mérito e INFL.			Razão Elétrica			Total UTE		
			P	M	L	P	M	L	P	M	L	P	M	L	P	M	L
CANDIOTA_3 (350)	Carvão	---															
PAMPA SUL (345)	Carvão	101,20															
SAO SEPE (8)	Biomassa	113,53	4,0	4,0	4,0				4,0	4,0	4,0				4,0	4,0	4,0
J.LACER. C (330)	Carvão	325,27	300,0	300,0	300,0				300,0	300,0	300,0				300,0	300,0	300,0
FIGUEIRA (20)	Carvão	330,64															
J.LACER. B (220)	Carvão	378,90	110,0	110,0	110,0				110,0	110,0	110,0				110,0	110,0	110,0
J.LAC. A2 (110)	Carvão	387,75															
J.LAC. A1 (80)	Carvão	453,14															
B.BONITA I (10)	Gás	778,35															
ARAUCARIA (484)	Gás	881,72															
URUGUAIANA (640)	Gás	1040,92															
CANOAS (249)	Gás	1328,09															
TOTAL SUL (2846)			414,0	414,0	414,0	0,0	0,0	0,0	414,0	414,0	414,0	0,0	0,0	0,0	414,0	414,0	414,0

O conteúdo desta publicação foi produzido pelo ONS com base em dados e informações de conhecimento público. É de responsabilidade exclusiva dos agentes e demais interessados a obtenção de outros dados e informações, a realização de análises, estudos e avaliações para fins de tomada de decisões, definição de estratégias de atuação, assunção de compromissos e obrigações e quaisquer outras finalidades, em qualquer tempo e sob qualquer condição. É proibida a reprodução ou utilização total ou parcial do presente sem a identificação da fonte.

REGIÃO NORDESTE

Térmicas Potência (MW)	Combustível	CVU	Inflexibilidade			Ordem de Mérito			Total Mérito e INFL.			Razão Elétrica			Total UTE		
			P	M	L	P	M	L	P	M	L	P	M	L	P	M	L
CAMPINA_GR (169)	Óleo	---															
MARACANAU (168)	Óleo	---															
PETROLINA (136)	Óleo	---															
POTIGUAR (53)	Diesel	---															
POTIGUAR_3 (66)	Diesel	---															
TERMOCABO (50)	Óleo	---															
TERMONE (171)	Óleo	---															
TERMOPB (171)	Óleo	---															
ERB CANDEI (17)	Biomassa	113,61	3,5	3,5	3,5				3,5	3,5	3,5				3,5	3,5	3,5
PROSP_I (28)	Gás	214,28															
PROSP_III (56)	Gás	218,33															
PSERGIPE I (1593)	GNL	365,30															
PROSP_II (37)	Gás	386,71	4,0	4,0	4,0				4,0	4,0	4,0				4,0	4,0	4,0
P.PECEM1 (720)	Carvão	405,42															
P.PECEM2 (365)	Carvão	409,76															
VALE ACU (368)	Gás	450,86	110,0	110,0	110,0				110,0	110,0	110,0				110,0	110,0	110,0
PERNAMBU_3 (201)	Óleo	955,76															
TERMOPE (550)	Gás	1065,05															
T.BAHIA (186)	Gás	1084,20															
SUAPE II (381)	Óleo	1132,68															
GLOBAL I (149)	Óleo	1259,59															
GLOBAL II (149)	Óleo	1259,59															
TERMOCEARA (223)	Gás	1997,98															
C.MURICY 2 (144)	Óleo	2609,71															
PECEM 2 (144)	Óleo	2636,99															
TOTAL NE (6007)			117,5	117,5	117,5	0,0	0,0	0,0	117,5	117,5	117,5	0,0	0,0	0,0	117,5	117,5	117,5

REGIÃO NORTE

Térmicas Potência (MW)	Combustível	CVU	Inflexibilidade			Ordem de Mérito			Total Mérito e INFL.			Razão Elétrica			Total UTE		
			P	M	L	P	M	L	P	M	L	P	M	L	P	M	L
C. ROCHA (85)	Gás	0,00	65,0	65,0	65,0				65,0	65,0	65,0				65,0	65,0	65,0
GERAMAR1 (166)	Óleo	---															
GERAMAR2 (166)	Óleo	---															
JARAQUI (75)	Gás	0,00	63,0	63,0	63,0				63,0	63,0	63,0				63,0	63,0	63,0
MANAUARA (73)	Gás	0,00	73,0	73,0	73,0				73,0	73,0	73,0				73,0	73,0	73,0
PONTA NEGR (73)	Gás	0,00	64,0	64,0	64,0				64,0	64,0	64,0				64,0	64,0	64,0
TAMBAQUI (93)	Gás	0,00	63,0	63,0	63,0				63,0	63,0	63,0				63,0	63,0	63,0
MARANHAO3 (519)	Gás	110,91	490,0	490,0	490,0				490,0	490,0	490,0				490,0	490,0	490,0
APARECIDA (166)	Gás	122,07	75,0	75,0	75,0				75,0	75,0	75,0				75,0	75,0	75,0
UTE MAUA 3 (591)	Gás	122,07	264,0	264,0	264,0				264,0	264,0	264,0	34,2			298,2	264,0	264,0
MARANHAO V (338)	Gás	232,61	75,0	60,0	40,0				75,0	60,0	40,0				75,0	60,0	40,0
MARANHAOIV (338)	Gás	232,61	75,0	60,0	40,0				75,0	60,0	40,0				75,0	60,0	40,0
PARNAIBA_V (386)	Vapor	239,30	110,0	90,0	55,0				110,0	90,0	55,0				110,0	90,0	55,0
N.VENECIA2 (270)	Gás	300,53	40,0	35,0	20,0				40,0	35,0	20,0				40,0	35,0	20,0
P. ITAQUI (360)	Carvão	401,48															
PARNAIB_IV (56)	Gás	517,49	20,0	15,0	10,0				20,0	15,0	10,0				20,0	15,0	10,0
TOTAL NORTE (4045)			1477,0	1417,0	1322,0	0,0	0,0	0,0	1477,0	1417,0	1322,0	34,2	0,0	0,0	1511,2	1417,0	1322,0

O conteúdo desta publicação foi produzido pelo ONS com base em dados e informações de conhecimento público. É de responsabilidade exclusiva dos agentes e demais interessados a obtenção de outros dados e informações, a realização de análises, estudos e avaliações para fins de tomada de decisões, definição de estratégias de atuação, assunção de compromissos e obrigações e quaisquer outras finalidades, em qualquer tempo e sob qualquer condição. É proibida a reprodução ou utilização total ou parcial do presente sem a identificação da fonte.