## 1. APRESENTAÇÃO

Na semana de 28/06 a 04/07/2025 houve precipitação nas bacias dos rios Uruguai, Jacuí, Taquari-Antas e Iguaçu.

Para a semana de 05/07 a 11/07/2025 não há previsão de precipitação significativa para as bacias hidrográficas de interesse do SIN.

Os valores médios semanais do Custo Marginal de Operação – CMO dos subsistemas do SIN sofreram as seguintes alterações em relação à semana anterior:

- SE/CO: de R$ 175,11/MWh para R$ 228,49/MWh
- Sul: de R$ 175,11/MWh para R$ 228,49/MWh
- Nordeste: de R$ 175,11/MWh para R$ 228,49/MWh
- Norte: de R$ 175,11/MWh para R$ 228,49/MWh

Desde o dia 01/01/2020, o despacho por ordem de mérito é indicado diariamente pelos resultados do modelo DESSEM. Assim, o despacho por ordem de mérito semanal, conforme publicado nesse documento, tem caráter apenas informativo. Da mesma forma, desde o dia 01/01/2021, a formação de preço deixou o formato semanal/patamar de carga e passou a ser horário, de acordo também com os resultados do modelo DESSEM.

## 2. NOTÍCIAS

Nos dias 24 e 25 de julho será realizada a reunião de elaboração do PMO de Agosto de 2025, com transmissão ao vivo através do site do ONS.

## 3. INFORMAÇÕES CONJUNTURAIS PARA ELABORAÇÃO DO PMO

### 3.1. Informações hidrometeorológicas

#### 3.1.1. Condições antecedentes

A atuação de áreas de instabilidade e a passagem de uma frente fria pela Região Sul no início da semana operativa provocaram precipitação nas bacias dos rios Uruguai, Jacuí, Taquari-Antas e Iguaçu (Figura 1). Em relação as demais bacias hidrográficas de interesse do SIN, não houve precipitação significativa.

O conteúdo desta publicação foi produzido pelo ONS com base em dados e informações de conhecimento público. É de responsabilidade exclusiva dos agentes e demais interessados a obtenção de outros dados e informações, a realização de análises, estudos e avaliações para fins de tomada de decisões, definição de estratégias de atuação, assunção de compromissos e obrigações e quaisquer outras finalidades, em qualquer tempo e sob qualquer condição. É proibida a reprodução ou utilização total ou parcial do presente sem a identificação da fonte.

Figura 1 – Precipitação observada (mm) no período de 28/06 a 03/07/2025

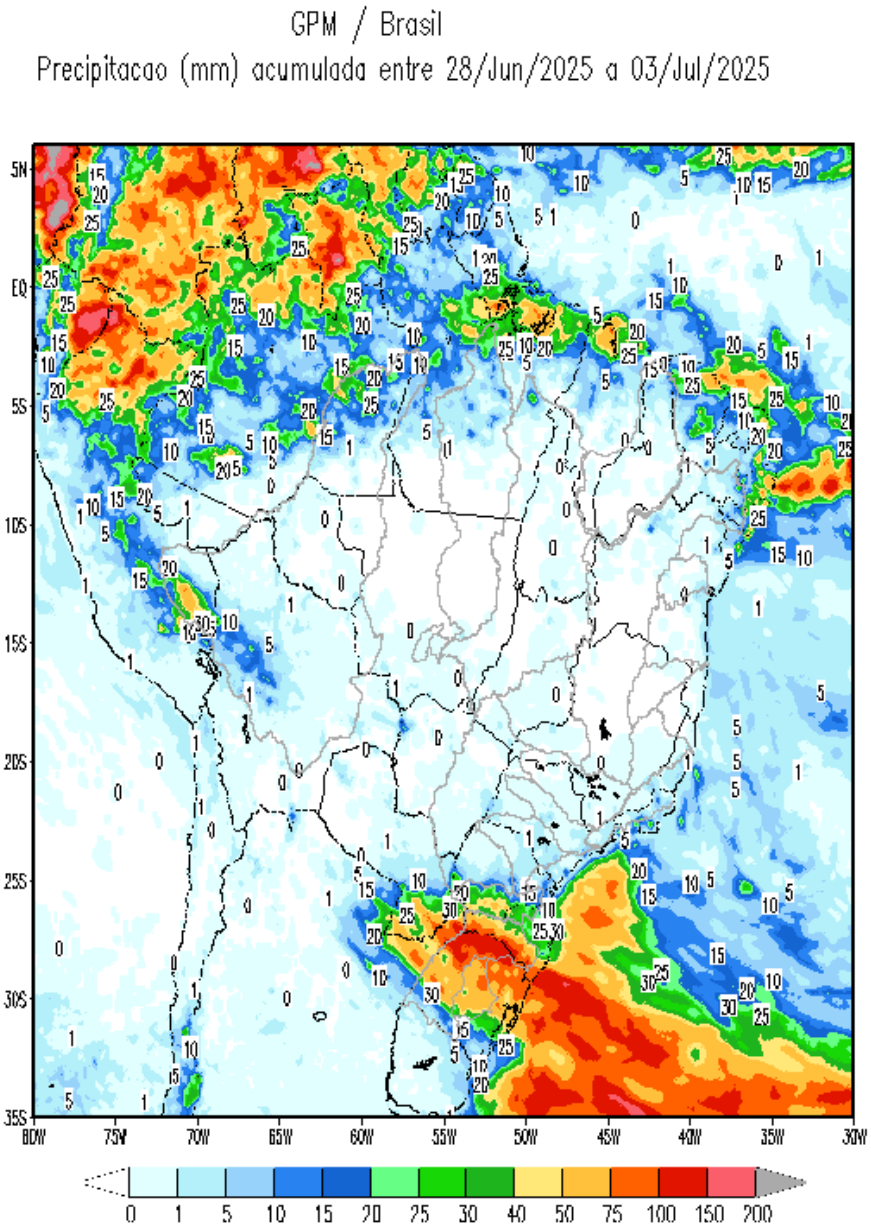


A Tabela 1 apresenta as energias naturais afluentes das semanas recentes. São apresentados os valores verificados na semana 21/06/2025 a 27/06/2025 e os estimados para fechamento da semana de 28/06/2025 a 04/07/2025.

Tabela 1 – Tendência hidrológica da ENA da revisão 1 de julho/2025

| Revisão 1 do PMO de Julho/2025 - ENAs | | | | |
|---|---|---|---|---|
| Subsistema | 21/06 a 27/06/2025 | | 28/06 a 04/07/2025 | |
| | MWmed | %MLT | MWmed | %MLT |
| SE/CO | 25.887 | 80 | 26.150 | 92 |
| S | 27.760 | 263 | 40.186 | 372 |
| NE | 1.816 | 40 | 1.741 | 43 |
| N | 5.103 | 48 | 4.270 | 56 |

O conteúdo desta publicação foi produzido pelo ONS com base em dados e informações de conhecimento público. É de responsabilidade exclusiva dos agentes e demais interessados a obtenção de outros dados e informações, a realização de análises, estudos e avaliações para fins de tomada de decisões, definição de estratégias de atuação, assunção de compromissos e obrigações e quaisquer outras finalidades, em qualquer tempo e sob qualquer condição. É proibida a reprodução ou utilização total ou parcial do presente sem a identificação da fonte.

### 3.1.2. Previsão para a próxima semana

Para a próxima semana operativa não há previsão de precipitação significativa para as bacias hidrográficas de interesse do SIN.

Figura 2 - Precipitação acumulada prevista pelo modelo ECMWF - período de 05 a 11/07/2025

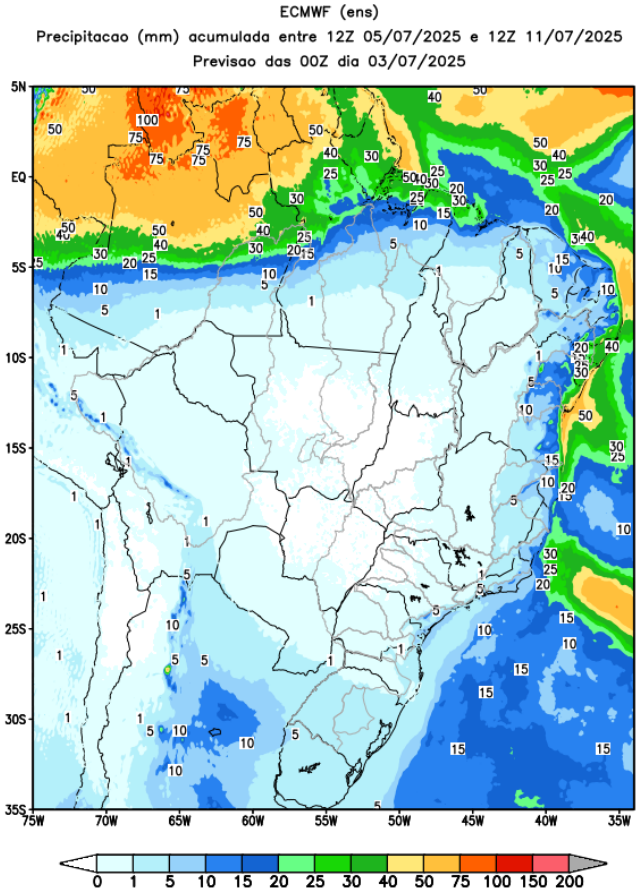


Em comparação com os valores estimados para a semana em curso, prevê-se para a próxima semana operativa recessão nas afluências de todos os subsistemas. A previsão mensal para julho indica a ocorrência de afluências abaixo da média histórica para os subsistemas Sudeste/Centro-Oeste, Nordeste e Norte e acima da média histórica para o subsistema Sul.

Tabela 2 – Previsão de ENAs da revisão 1 de Julho/2025

| Revisão 1 do PMO de Julho/2025 - ENAs previstas | | | | |
|---|---|---|---|---|
| Subsistema | 05/07 a 11/07/2025 | | Mês de julho | |
| | MWmed | %MLT | MWmed | %MLT |
| SE/CO | 22.662 | 89 | 21.159 | 83 |
| S | 13.146 | 120 | 12.569 | 115 |
| NE | 1.547 | 41 | 1.519 | 41 |
| N | 3.699 | 71 | 3.330 | 64 |

O conteúdo desta publicação foi produzido pelo ONS com base em dados e informações de conhecimento público. É de responsabilidade exclusiva dos agentes e demais interessados a obtenção de outros dados e informações, a realização de análises, estudos e avaliações para fins de tomada de decisões, definição de estratégias de atuação, assunção de compromissos e obrigações e quaisquer outras finalidades, em qualquer tempo e sob qualquer condição. É proibida a reprodução ou utilização total ou parcial do presente sem a identificação da fonte.

As figuras a seguir ilustram as ENAs semanais verificadas e previstas para o PMO e para a Revisão 1 do PMO de Julho/2025.

Figura 3 - Energias Naturais Afluentes ao subsistema Sudeste/Centro-Oeste do PMO e da Revisão 1 do PMO de Julho/2025

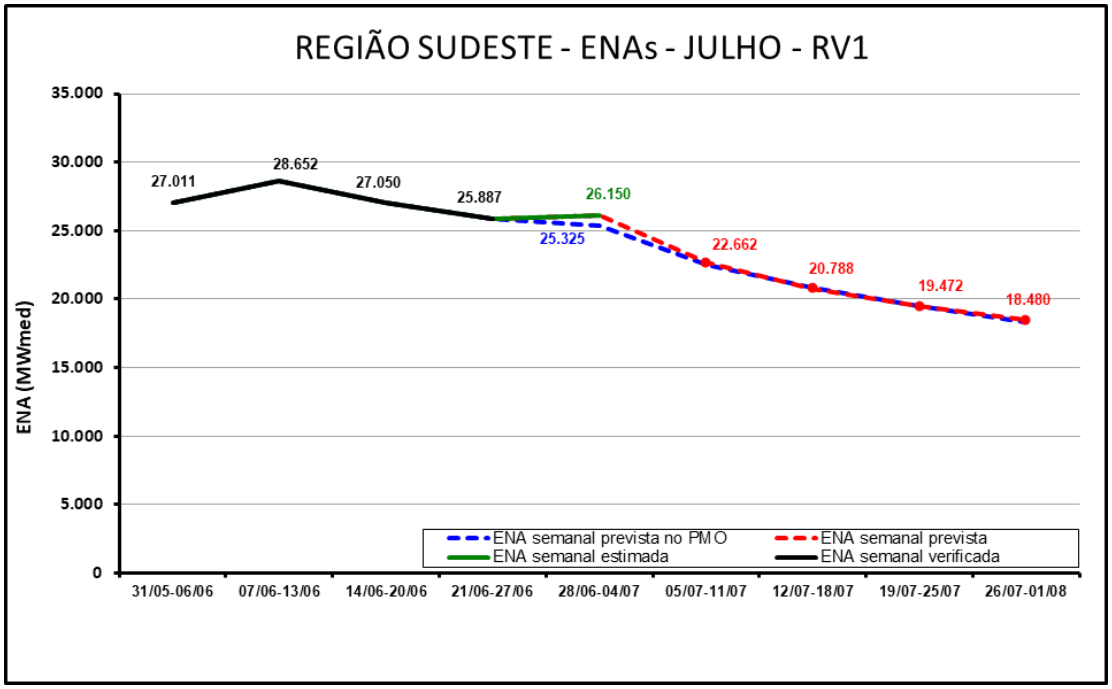


Figura 4 - Energias Naturais Afluentes ao subsistema Sul do PMO e da Revisão 1 do PMO de Julho/2025

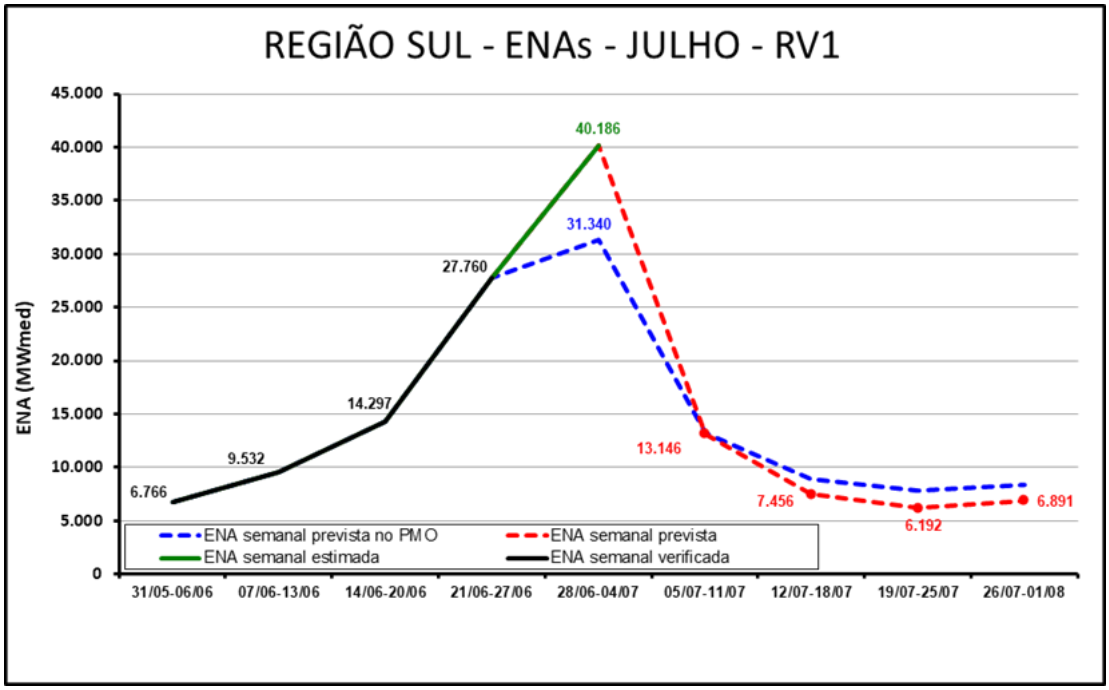


O conteúdo desta publicação foi produzido pelo ONS com base em dados e informações de conhecimento público. É de responsabilidade exclusiva dos agentes e demais interessados a obtenção de outros dados e informações, a realização de análises, estudos e avaliações para fins de tomada de decisões, definição de estratégias de atuação, assunção de compromissos e obrigações e quaisquer outras finalidades, em qualquer tempo e sob qualquer condição. É proibida a reprodução ou utilização total ou parcial do presente sem a identificação da fonte.

Figura 5 - Energias Naturais Afluentes ao subsistema Nordeste do PMO e da Revisão 1 do PMO de Julho/2025

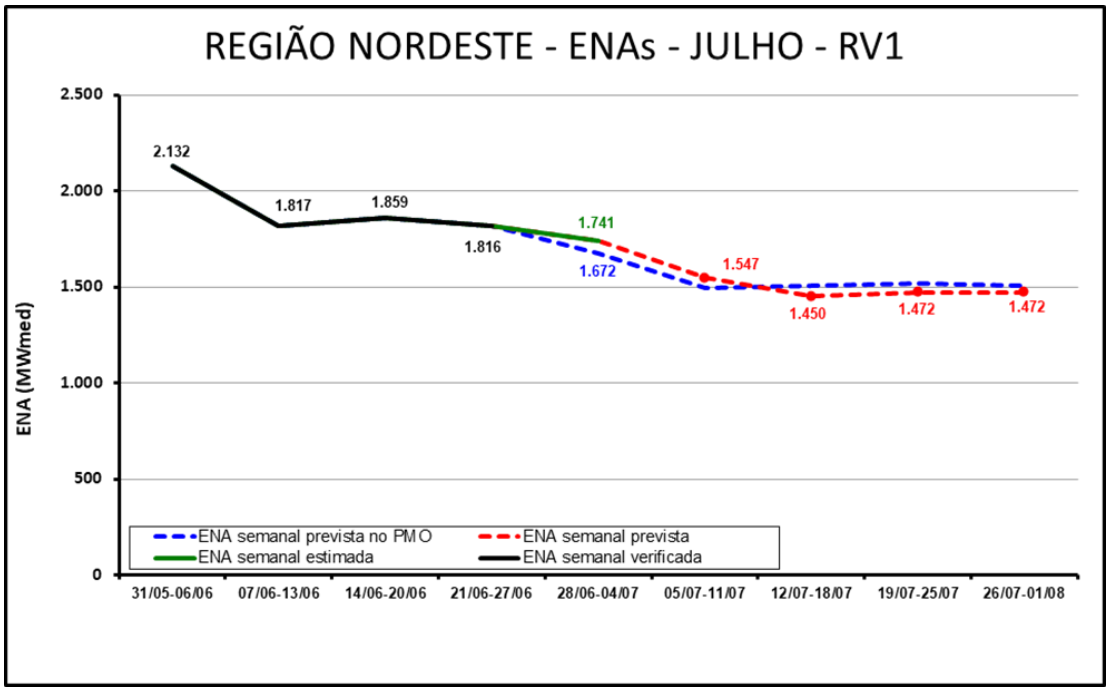


Figura 6 - Energias Naturais Afluentes ao subsistema Norte do PMO e da Revisão 1 do PMO de Julho/2025

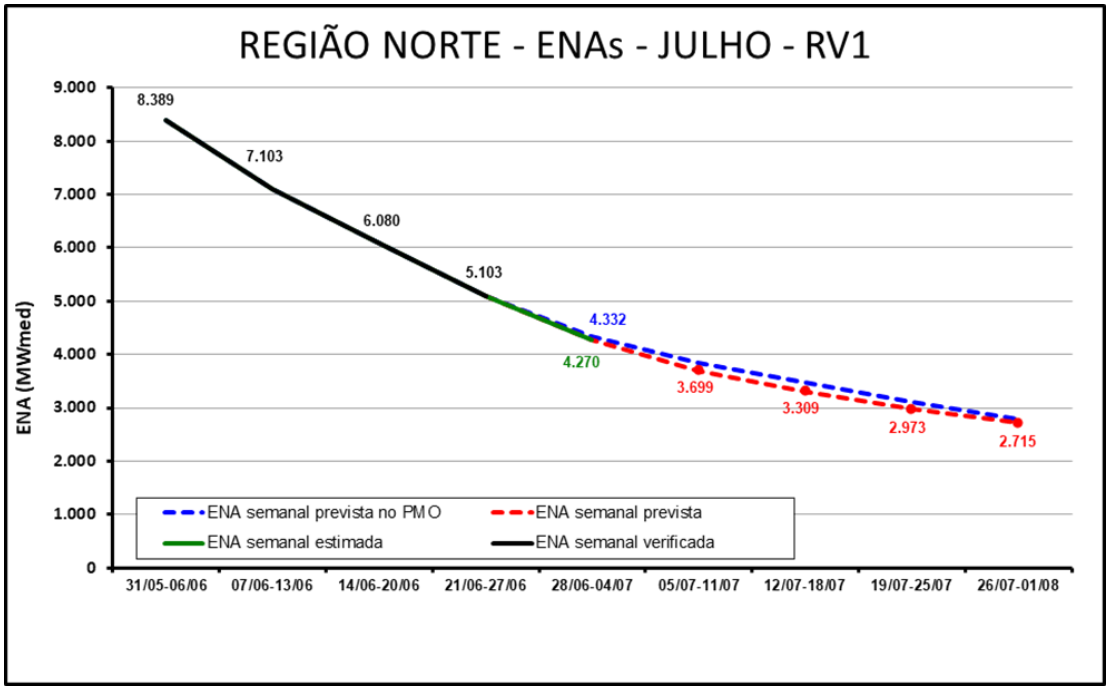


O conteúdo desta publicação foi produzido pelo ONS com base em dados e informações de conhecimento público. É de responsabilidade exclusiva dos agentes e demais interessados a obtenção de outros dados e informações, a realização de análises, estudos e avaliações para fins de tomada de decisões, definição de estratégias de atuação, assunção de compromissos e obrigações e quaisquer outras finalidades, em qualquer tempo e sob qualquer condição. É proibida a reprodução ou utilização total ou parcial do presente sem a identificação da fonte.

### 3.1.3. Cenários de ENAs para a Revisão 1 de Julho/2025

As figuras a seguir apresentam as características dos cenários de energias naturais afluentes gerados na Revisão 1 de julho/2025, para acoplamento com a FCF do mês de agosto/2025. São mostradas, para os quatro subsistemas, as amplitudes e as Funções de Distribuição Acumulada dos cenários de ENA, comparativamente com os valores considerados para o PMO de Julho/2025.

Figura 7 - Amplitude dos Cenários de ENA para o Subsistema Sudeste/Centro-Oeste, em %MLT, para a Revisão 1 de Julho/2025

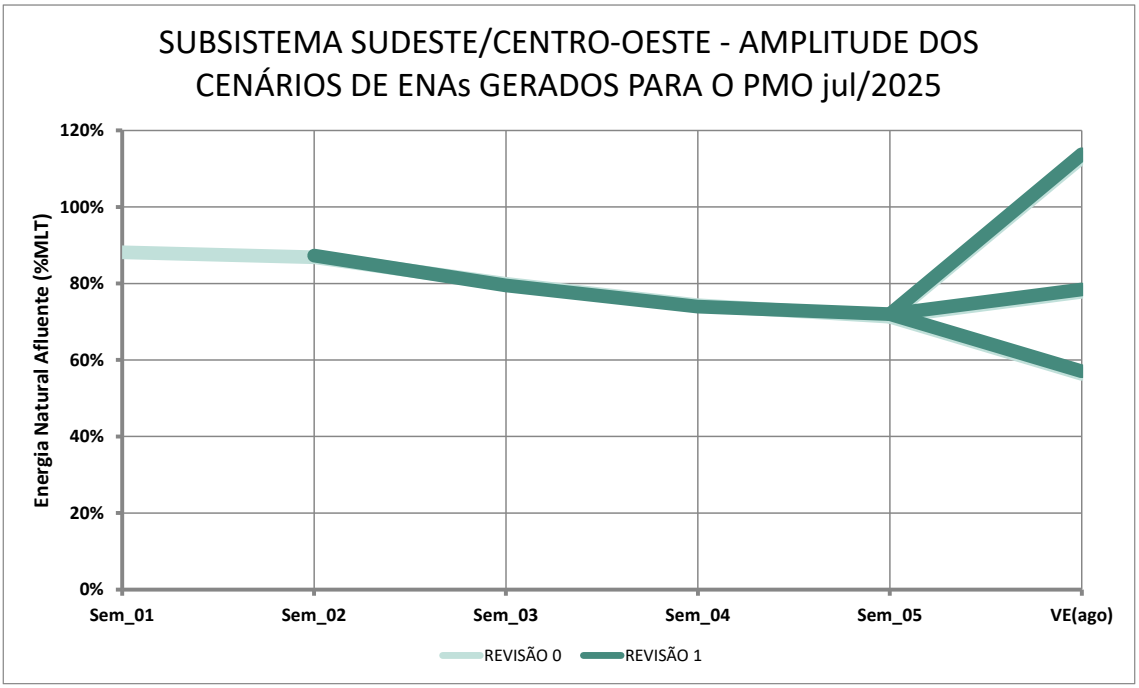


Figura 8 - Função de Distribuição Acumulada dos Cenários para o Subsistema Sudeste/Centro-Oeste para a Revisão 1 de Julho/2025

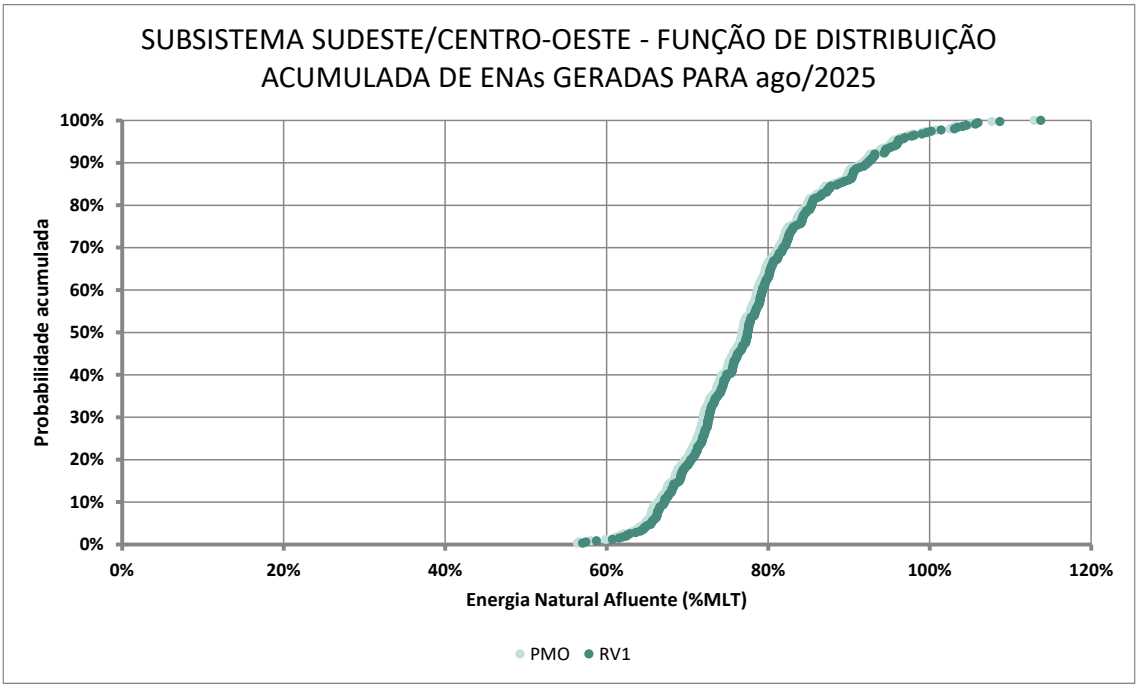


O conteúdo desta publicação foi produzido pelo ONS com base em dados e informações de conhecimento público. É de responsabilidade exclusiva dos agentes e demais interessados a obtenção de outros dados e informações, a realização de análises, estudos e avaliações para fins de tomada de decisões, definição de estratégias de atuação, assunção de compromissos e obrigações e quaisquer outras finalidades, em qualquer tempo e sob qualquer condição. É proibida a reprodução ou utilização total ou parcial do presente sem a identificação da fonte.

Figura 9 - Amplitude dos Cenários de ENA para o Subsistema Sul, em %MLT, para a Revisão 1 de Julho/2025

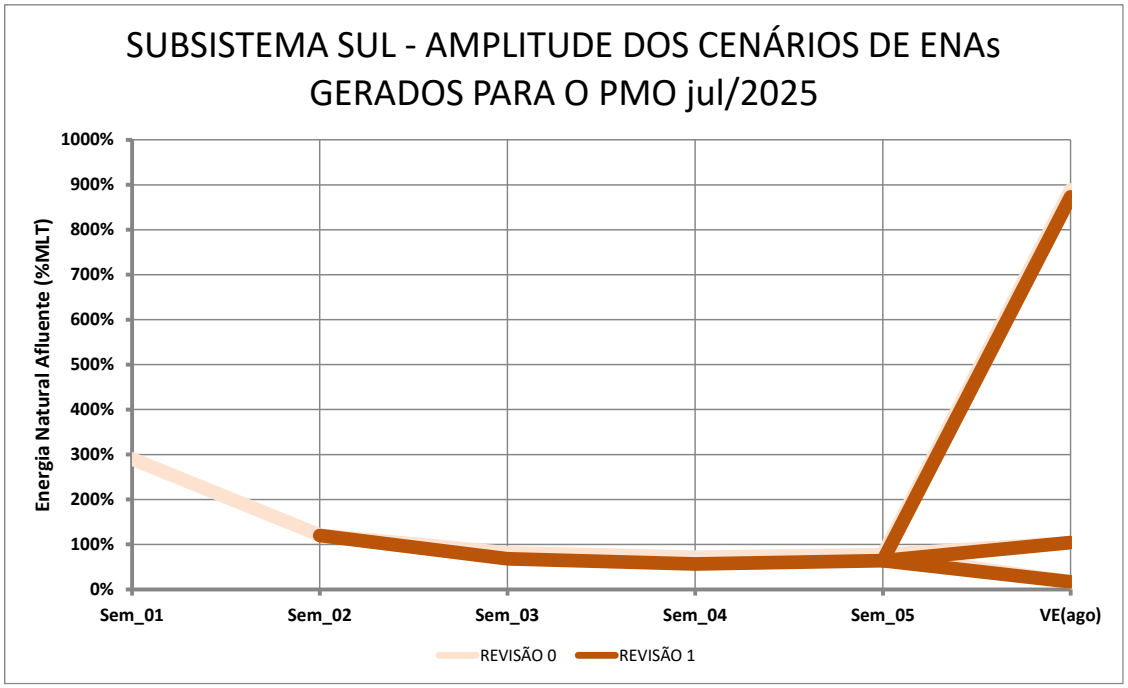


Figura 10 - Função de Distribuição Acumulada dos Cenários para o Subsistema Sul para a Revisão 1 de Julho/2025

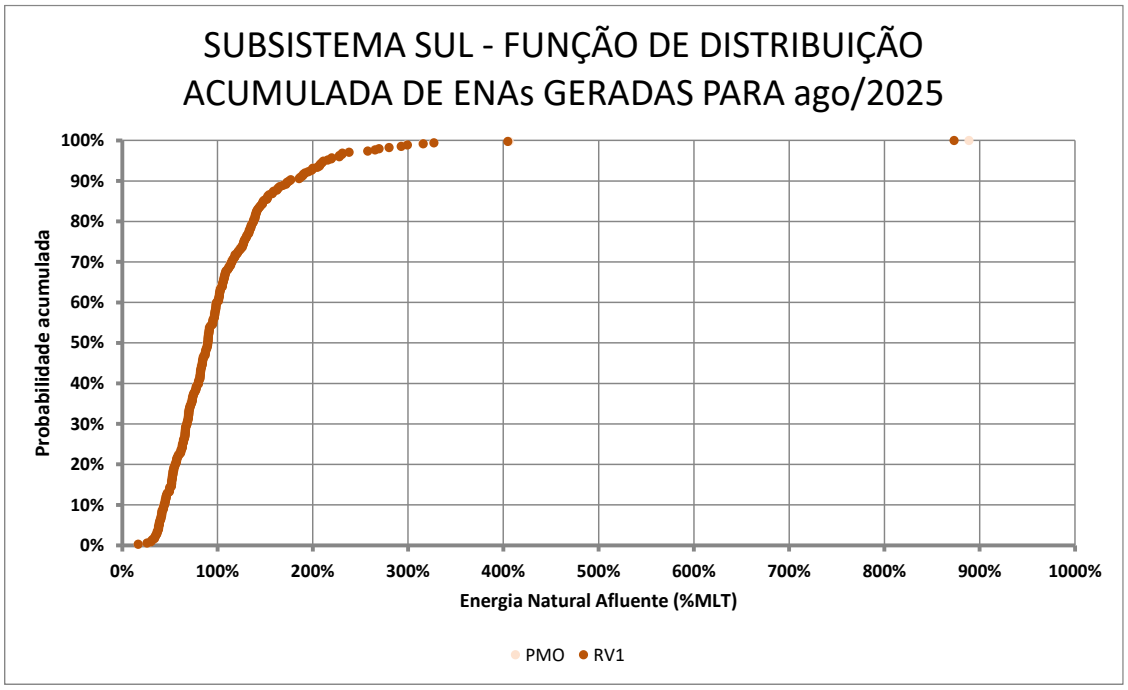


O conteúdo desta publicação foi produzido pelo ONS com base em dados e informações de conhecimento público. É de responsabilidade exclusiva dos agentes e demais interessados a obtenção de outros dados e informações, a realização de análises, estudos e avaliações para fins de tomada de decisões, definição de estratégias de atuação, assunção de compromissos e obrigações e quaisquer outras finalidades, em qualquer tempo e sob qualquer condição. É proibida a reprodução ou utilização total ou parcial do presente sem a identificação da fonte.

Figura 11 - Amplitude dos Cenários de ENA para o Subsistema Nordeste em %MLT, para a Revisão 1 de Julho/2025

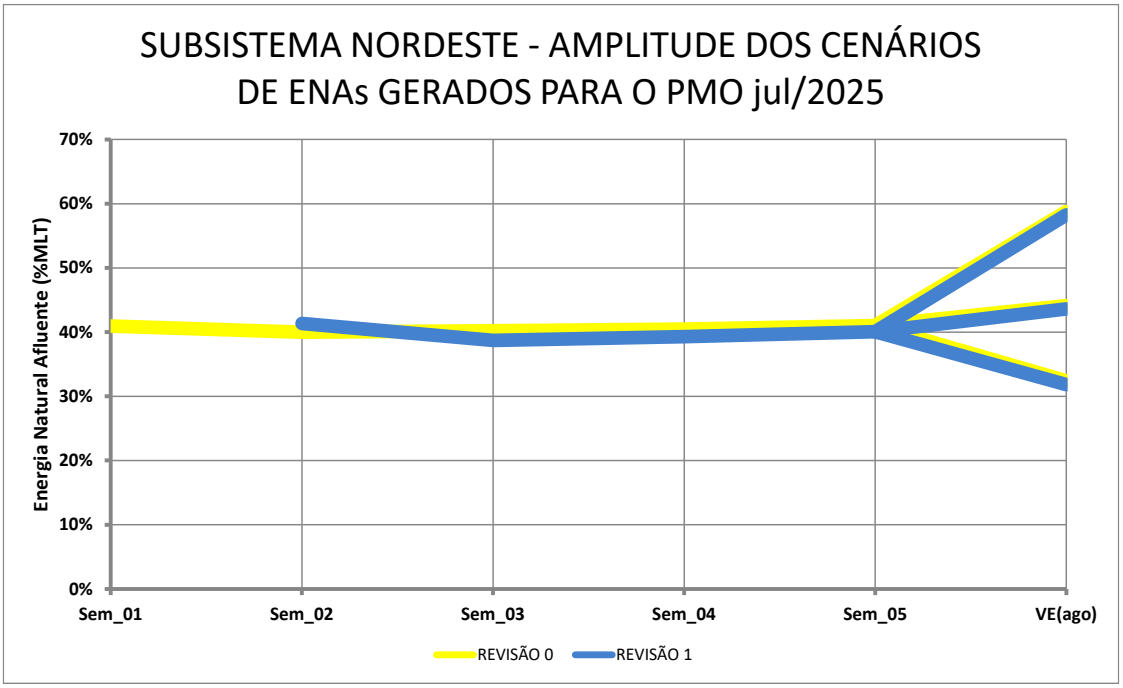


Figura 12 - Função de Distribuição Acumulada dos Cenários para o Subsistema Nordeste para a Revisão 1 de Julho/2025

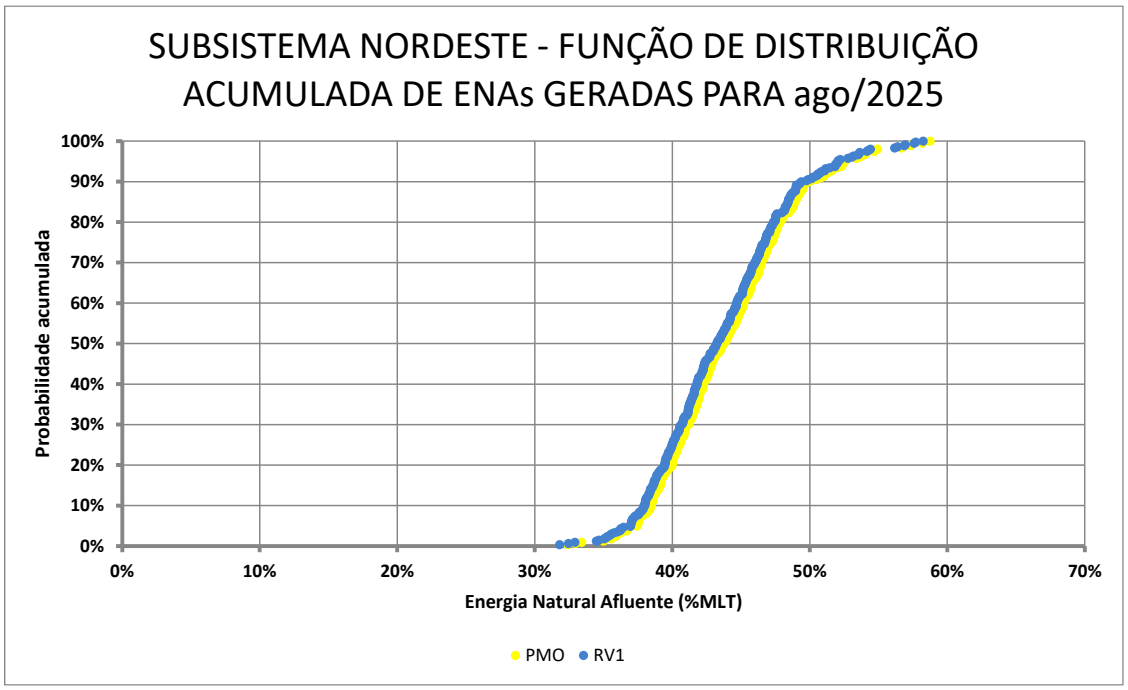


O conteúdo desta publicação foi produzido pelo ONS com base em dados e informações de conhecimento público. É de responsabilidade exclusiva dos agentes e demais interessados a obtenção de outros dados e informações, a realização de análises, estudos e avaliações para fins de tomada de decisões, definição de estratégias de atuação, assunção de compromissos e obrigações e quaisquer outras finalidades, em qualquer tempo e sob qualquer condição. É proibida a reprodução ou utilização total ou parcial do presente sem a identificação da fonte.

Figura 13 - Amplitude dos Cenários de ENA para o Subsistema Norte, em %MLT, para a Revisão 1 de Julho/2025

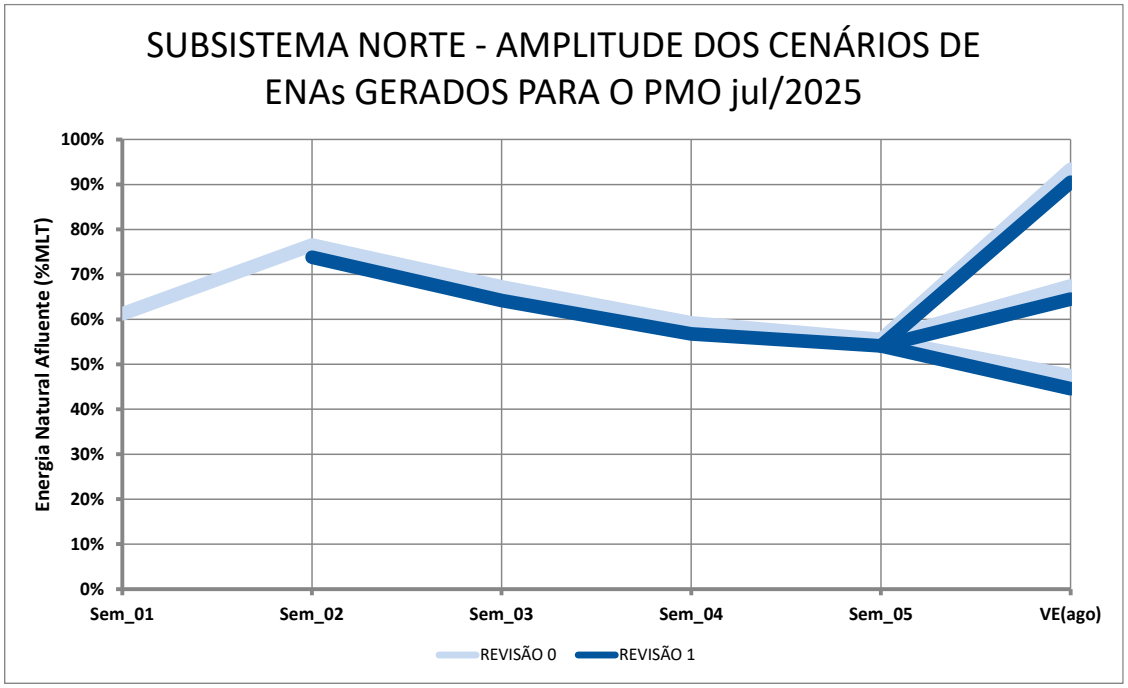


Figura 14 - Função de Distribuição Acumulada dos Cenários para o Subsistema Norte para a Revisão 1 de Julho/2025

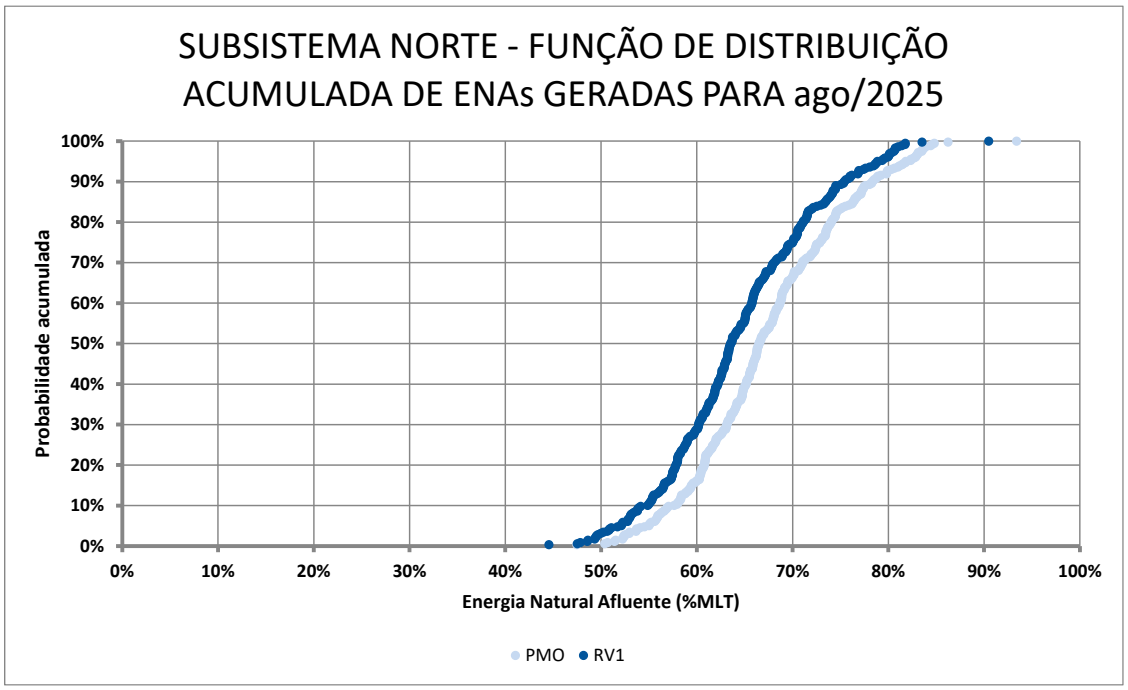


O conteúdo desta publicação foi produzido pelo ONS com base em dados e informações de conhecimento público. É de responsabilidade exclusiva dos agentes e demais interessados a obtenção de outros dados e informações, a realização de análises, estudos e avaliações para fins de tomada de decisões, definição de estratégias de atuação, assunção de compromissos e obrigações e quaisquer outras finalidades, em qualquer tempo e sob qualquer condição. É proibida a reprodução ou utilização total ou parcial do presente sem a identificação da fonte.

Os valores da MLT (Média de Longo Termo) das energias naturais afluentes para os meses de julho/2025 e agosto/2025 são apresentados na tabela a seguir.

Tabela 3 – MLT da ENA nos meses de julho/2025 e agosto/2025

| MLT das ENAs (MWmed) | | |
|---|---|---|
| Subsistema | julho | agosto |
| SE/CO | 25.581 | 20.527 |
| S | 10.957 | 9.984 |
| NE | 3.744 | 3.267 |
| N | 5.241 | 3.174 |

## 3.2. Limites de Intercâmbio entre Subsistemas

Os limites elétricos de intercâmbio de energia entre subsistemas são de fundamental importância para o processo de otimização energética, sendo determinantes para a definição das políticas de operação e do CMO para cada subsistema. Estes limites são influenciados por intervenções na malha de transmissão, notadamente na primeira semana operativa. O diagrama a seguir ilustra os fluxos notáveis do SIN e os limites aplicados neste PMO.

Figura 15 – Interligações entre regiões

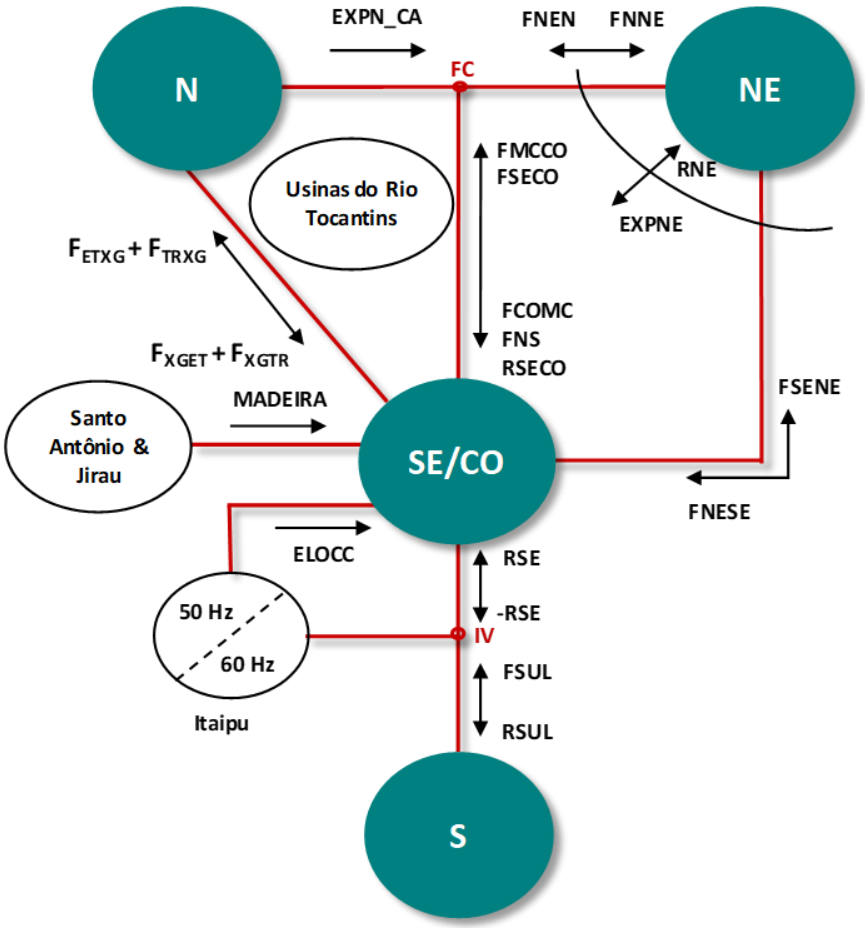


O conteúdo desta publicação foi produzido pelo ONS com base em dados e informações de conhecimento público. É de responsabilidade exclusiva dos agentes e demais interessados a obtenção de outros dados e informações, a realização de análises, estudos e avaliações para fins de tomada de decisões, definição de estratégias de atuação, assunção de compromissos e obrigações e quaisquer outras finalidades, em qualquer tempo e sob qualquer condição. É proibida a reprodução ou utilização total ou parcial do presente sem a identificação da fonte.

Tabela 4 – Limites considerados nesta semana operativa para intercâmbio de energia

| Limites de Intercâmbio (MWmed) | | | | |
|---|---|---|---|---|
| Fluxo | Patamar | 05/07 a 11/07/2025 | | Demais Semanas |
| RNE | Pesada | 11.000 | | 11.000 |
| | Média | 11.000 | | 11.000 |
| | Leve | 11.000 | | 11.000 |
| FNS | Pesada | 5.100 | (A) (B) (C) (D) (E) (F) (G) (H) (I) | 5.200 |
| | Média | 4.858 | | 5.200 |
| | Leve | 3.624 | | 5.000 |
| FNNE | Pesada | 7.800 | (J) | 7.800 |
| | Média | 7.800 | | 7.800 |
| | Leve | 7.244 | | 7.800 |
| EXPORT. NE | Pesada | 13.800 | | 13.800 |
| | Média | 13.800 | | 13.800 |
| | Leve | 13.800 | | 13.800 |
| FMCCO | Pesada | 5.000 | | 5.000 |
| | Média | 5.000 | | 5.000 |
| | Leve | 5.000 | | 5.000 |
| FSENE | Pesada | 6.000 | | 6.000 |
| | Média | 6.000 | | 6.000 |
| | Leve | 6.000 | | 6.000 |
| FNS + FNESE | Pesada | 11.100 | (A) (C) (F) (G) (H) (I) | 11.200 |
| | Média | 10.025 | | 10.174 |
| | Leve | 10.974 | | 11.200 |
| RSE | Pesada | 10.100 | (K) (L) | 10.200 |
| | Média | 9.915 | | 10.200 |
| | Leve | 10.483 | | 10.880 |
| FORNEC. SUL | Pesada | 7.000 | | 7.000 |
| | Média | 7.000 | | 7.000 |
| | Leve | 8.600 | | 8.600 |

| Limites de Intercâmbio (MWmed) | | | | |
|---|---|---|---|---|
| Fluxo | Patamar | 05/07 a 11/07/2025 | | Demais Semanas |
| RECEB. SUL | Pesada | 8.955 | (B) (K) (L) | 9.025 |
| | Média | 5.743 | | 6.075 |
| | Leve | 7.966 | | 10.425 |
| ELO CC 50 Hz | Pesada | 3.132 | (M) | 3.132 |
| | Média | 3.132 | | 3.132 |
| | Leve | 2.954 | | 3.132 |
| ITAIPU 60 Hz | Pesada | 7.500 | | 7.500 |
| | Média | 7.500 | | 7.500 |
| | Leve | 7.500 | | 7.500 |
| EXP. N CA | Pesada | 8.000 | | 8.000 |
| | Média | 8.000 | | 8.000 |
| | Leve | 8.000 | | 8.000 |
| FETXG + FTRXG | Pesada | 4.200 | | 4.200 |
| | Média | 4.200 | | 4.200 |
| | Leve | 4.200 | | 4.200 |
| FXGET + FXGTR | Pesada | 3.000 | | 3.000 |
| | Média | 3.000 | | 3.000 |
| | Leve | 3.000 | | 3.000 |
| FNESE | Pesada | 8.160 | (B) (C) (D) (E) (J) (N) (O) (P) | 8.500 |
| | Média | 7.781 | | 8.318 |
| | Leve | 7.182 | | 8.500 |
| FNEN | Pesada | 6.200 | (J) (Q) (R) | 6.200 |
| | Média | 6.154 | | 6.200 |
| | Leve | 5.631 | | 6.200 |
| Ger_MADEIRA | Pesada | 6.863 | (B) (M) (S) | 7.223 |
| | Média | 6.903 | | 7.242 |
| | Leve | 6.625 | | 7.284 |

(A) SGI 32.691-25
(B) SGI 36.710-25
(C) SGI 37.052-25
(D) SGI 37.064-25
(E) SGI 37.067-25
(F) SGI 37.299-25
(G) SGI 37.745-25
(H) SGI 38.045-25
(I) SGI 38.052-25
(J) SGI 35.168-25
(K) SGI 39.739-25
(L) SGI 40.311-25
(M) SGI 36.702-25
(N) SGI 37.069-25
(O) SGI 38.068-25
(P) SGI 38.410-25
(Q) SGI 35.182-25
(R) SGI 36.139-25
(S) SGI 37.091-25

O conteúdo desta publicação foi produzido pelo ONS com base em dados e informações de conhecimento público. É de responsabilidade exclusiva dos agentes e demais interessados a obtenção de outros dados e informações, a realização de análises, estudos e avaliações para fins de tomada de decisões, definição de estratégias de atuação, assunção de compromissos e obrigações e quaisquer outras finalidades, em qualquer tempo e sob qualquer condição. É proibida a reprodução ou utilização total ou parcial do presente sem a identificação da fonte.

### 3.3. Previsão de carga

A partir do fechamento dos valores do PMO de Julho, as projeções de carga indicam variações de -1,9% no Subsistema Sudeste/Centro-Oeste, 1,5% no Subsistema Sul, 3,7% no Subsistema Nordeste e 4,4% no Subsistema Norte, em relação ao mesmo mês do ano anterior. Os principais fatores que explicam essas variações são descritos a seguir.

A estimativa de fechamento da carga global de energia na semana operativa atual (28/06 a 04/07) aponta, no Sistema Interligado Nacional (SIN), um resultado 0,04% superior ao da semana anterior (21/06 a 27/06), consolidando uma expectativa de 75.251 MW médios. Esse resultado reflete a compensação entre os Subsistemas Sudeste/Centro-Oeste e Sul: o primeiro apresentou valores verificados abaixo das previsões, enquanto o segundo registrou carga significativamente superior ao estimado para esta semana.

Na análise por Subsistemas, o Sudeste/Centro-Oeste apresentou desvio de -1,1%, mantendo o bom desempenho preditivo das últimas semanas, mesmo com a influência de regiões com alta variabilidade de temperatura e precipitação. No Sul, o desvio foi significativo, de 8,9%, explicado pelas temperaturas mais baixas e consequente impacto da carga de aquecimento nas áreas mais frias.

Os Subsistemas Nordeste e Norte apresentaram desvios de -3,4% e -0,9%, respectivamente. No Nordeste, a ocorrência de elevada de precipitação contribuiu para a carga verificada abaixo do previsto. Já no Norte, a previsão manteve-se próxima ao valor realizado, evidenciando boa assertividade.

Para a próxima semana operativa (05/07 a 11/07), projeta-se manutenção da carga do SIN, com expectativa de 74.909 MW médios, em nível semelhante ao atual. As previsões meteorológicas indicam estabilidade nas temperaturas e nos acumulados de precipitação em relação à semana vigente, especialmente no Sudeste (com máximas entre 21 °C e 26 °C), Nordeste e Norte. No Sul, a sinalização de elevação das temperaturas tende a atenuar o efeito da carga de aquecimento observado na semana atual.

Tabela 5 – Evolução da carga do PMO de Julho de 2025

| Subsistema | CARGA SEMANAL (MWmed) | | | | | CARGA MENSAL (MWmed) | |
|---|---|---|---|---|---|---|---|
| | 1ª Sem | 2ª Sem | 3ª Sem | 4ª Sem | 5ª Sem | jul/25 | Var. (%) jul/25 -> jul/24 |
| SE/CO | 40.757 | 40.548 | 41.826 | 41.985 | 41.906 | 41.451 | -1,9% |
| Sul | 13.929 | 13.737 | 13.525 | 13.512 | 13.455 | 13.609 | 1,5% |
| Nordeste | 12.562 | 12.565 | 12.967 | 12.999 | 12.998 | 12.837 | 3,7% |
| Norte | 8.003 | 8.059 | 8.140 | 8.159 | 8.158 | 8.112 | 4,4% |
| **SIN** | **75.251** | **74.909** | **76.457** | **76.656** | **76.518** | **76.009** | **0,3%** |

O conteúdo desta publicação foi produzido pelo ONS com base em dados e informações de conhecimento público. É de responsabilidade exclusiva dos agentes e demais interessados a obtenção de outros dados e informações, a realização de análises, estudos e avaliações para fins de tomada de decisões, definição de estratégias de atuação, assunção de compromissos e obrigações e quaisquer outras finalidades, em qualquer tempo e sob qualquer condição. É proibida a reprodução ou utilização total ou parcial do presente sem a identificação da fonte.

### 3.4. Potência Hidráulica Total Disponível no SIN

O gráfico a seguir mostra a disponibilidade hidráulica total do SIN, para este mês, de acordo com o cronograma de manutenção informado pelos agentes para esta revisão.

Figura 16 – Potência hidráulica disponível no SIN

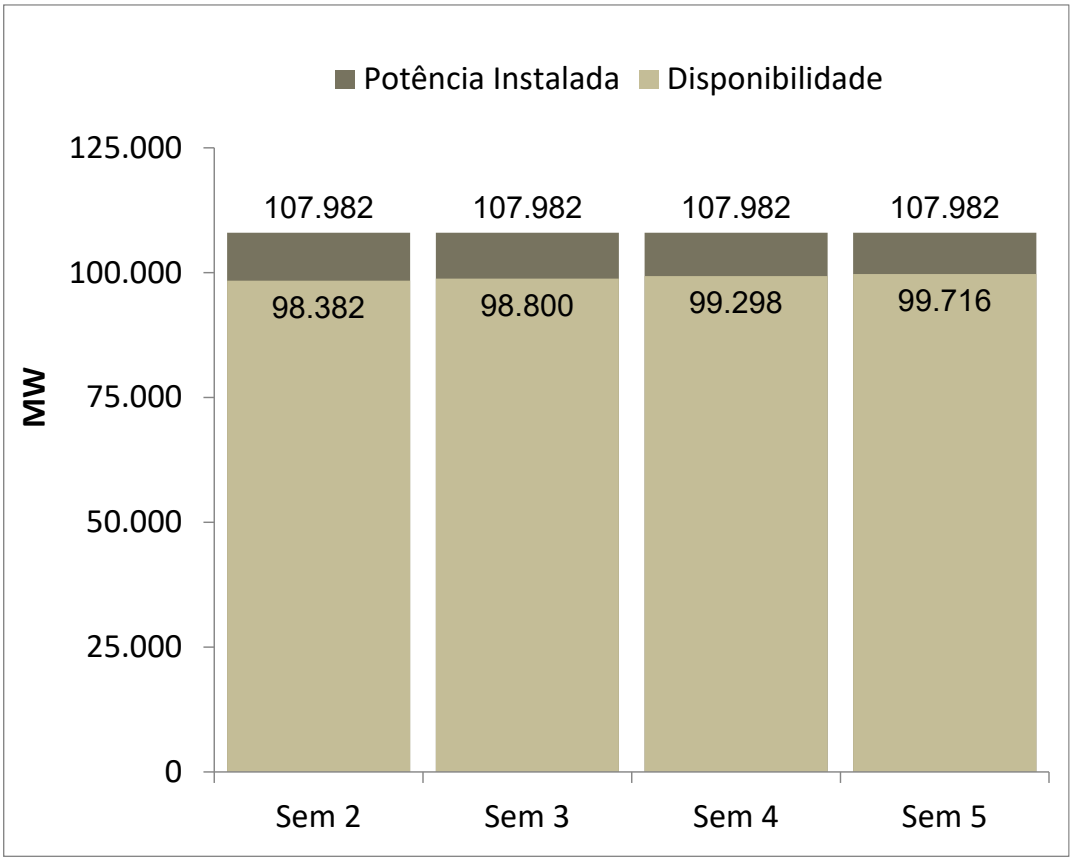


### 3.5. Armazenamentos Iniciais por Subsistema

Tabela 6 – Armazenamentos iniciais, por subsistema, considerados para esta semana operativa

| Armazenamento (%EARmáx) - 0:00 h do dia 05/07/2025 | | |
|---|---|---|
| **Subsistema** | **Nível previsto no PMO Jul/2025** | **Partida informada pelos Agentes para a Revisão 1 do PMO Jul/2025** |
| **SE/CO** | 66,8 | 66,2 |
| **S** | 86,7 | 88,9 |
| **NE** | 68,7 | 68,5 |
| **N** | 97,8 | 96,6 |

A primeira coluna da tabela acima corresponde ao armazenamento previsto no PMO de Julho de 2025, para a 0:00 h do dia 05/07/2025. A segunda coluna apresenta os armazenamentos obtidos a partir dos níveis de partida informados pelos Agentes de Geração para seus aproveitamentos com reservatórios.

O conteúdo desta publicação foi produzido pelo ONS com base em dados e informações de conhecimento público. É de responsabilidade exclusiva dos agentes e demais interessados a obtenção de outros dados e informações, a realização de análises, estudos e avaliações para fins de tomada de decisões, definição de estratégias de atuação, assunção de compromissos e obrigações e quaisquer outras finalidades, em qualquer tempo e sob qualquer condição. É proibida a reprodução ou utilização total ou parcial do presente sem a identificação da fonte.

## 4. PRINCIPAIS RESULTADOS

### 4.1. Política de Operação Energética

Para esta semana operativa, está prevista a seguinte política de intercâmbio de energia entre regiões:

Região SE/CO:

- Utilização dos recursos das bacias dos rios Grande e Paranaíba, conforme necessidade de alocação para o atendimento à ponta de carga e controle de nível dos reservatórios;

- Avaliação semanal de manutenção da política de redução das defluências do Paraná.

Região Sul:

- Exploração da geração hidráulica para controle do nível dos reservatórios.

Região NE:

- Operação minimizada, com redução de geração na cascata do Rio São Francisco, considerando que o reservatório de Sobradinho entrou faixa de atenção.

Região Norte:

- Geração dimensionada para atendimento à ponta de carga;

- Tocantins operando em período de praias e Tucuruí seguindo a curva de referência.

### 4.2. Custo Marginal de Operação – CMO

A figura a seguir apresenta os Custos Marginais de Operação, em valores médios semanais, para as semanas operativas deste mês.

Figura 17 – CMO em valores médios

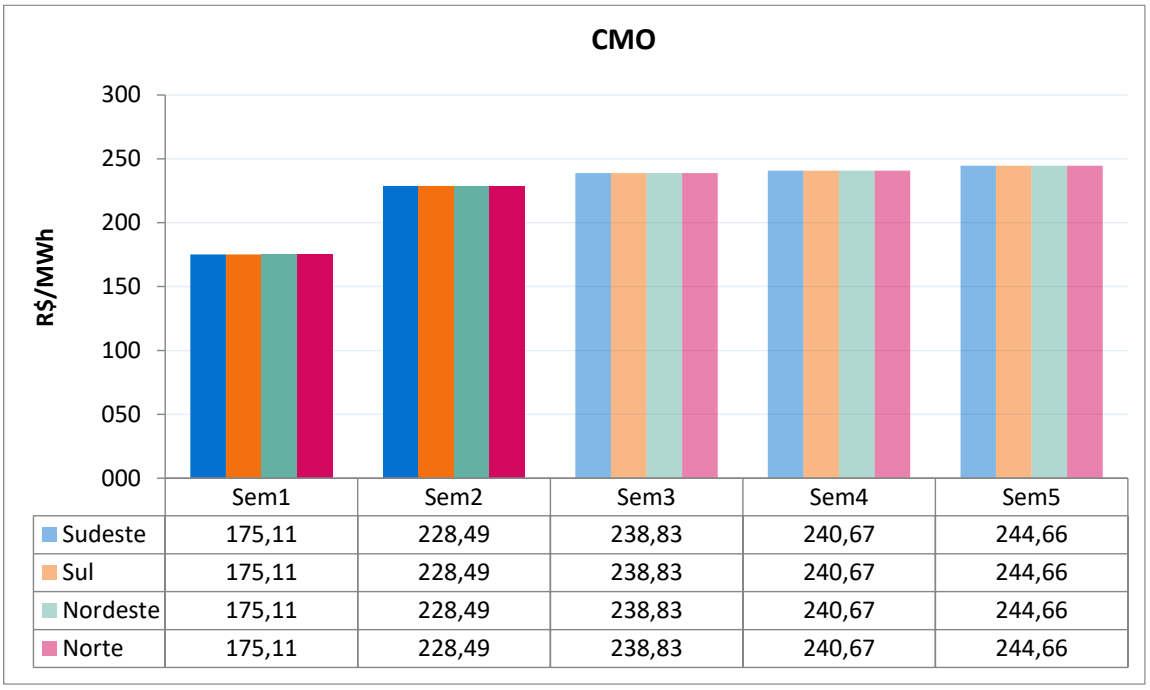


| | Sem1 | Sem2 | Sem3 | Sem4 | Sem5 |
|---|---|---|---|---|---|
| Sudeste | 175,11 | 228,49 | 238,83 | 240,67 | 244,66 |
| Sul | 175,11 | 228,49 | 238,83 | 240,67 | 244,66 |
| Nordeste | 175,11 | 228,49 | 238,83 | 240,67 | 244,66 |
| Norte | 175,11 | 228,49 | 238,83 | 240,67 | 244,66 |

O conteúdo desta publicação foi produzido pelo ONS com base em dados e informações de conhecimento público. É de responsabilidade exclusiva dos agentes e demais interessados a obtenção de outros dados e informações, a realização de análises, estudos e avaliações para fins de tomada de decisões, definição de estratégias de atuação, assunção de compromissos e obrigações e quaisquer outras finalidades, em qualquer tempo e sob qualquer condição. É proibida a reprodução ou utilização total ou parcial do presente sem a identificação da fonte.

A tabela a seguir apresenta o custo marginal de operação, por subsistema e patamar de carga, para a próxima semana operativa.

Tabela 7 – CMO para esta semana operativa

| Patamares de Carga | CMO (R$/MWh) | | | |
|---|---|---|---|---|
| | SE/CO | S | NE | N |
| Pesada | 235,02 | 235,02 | 235,02 | 235,02 |
| Média | 229,90 | 229,90 | 229,90 | 229,90 |
| Leve | 225,22 | 225,22 | 225,22 | 225,22 |
| Média Semanal | 228,49 | 228,49 | 228,49 | 228,49 |

## 4.3. Energia Armazenada

O processo de otimização realizado pelo programa DECOMP indicou os armazenamentos mostrados na figura a seguir para as próximas semanas operativas do mês de julho/2025.

Figura 18 – Energias Armazenadas nas semanas operativas do mês de julho/2025

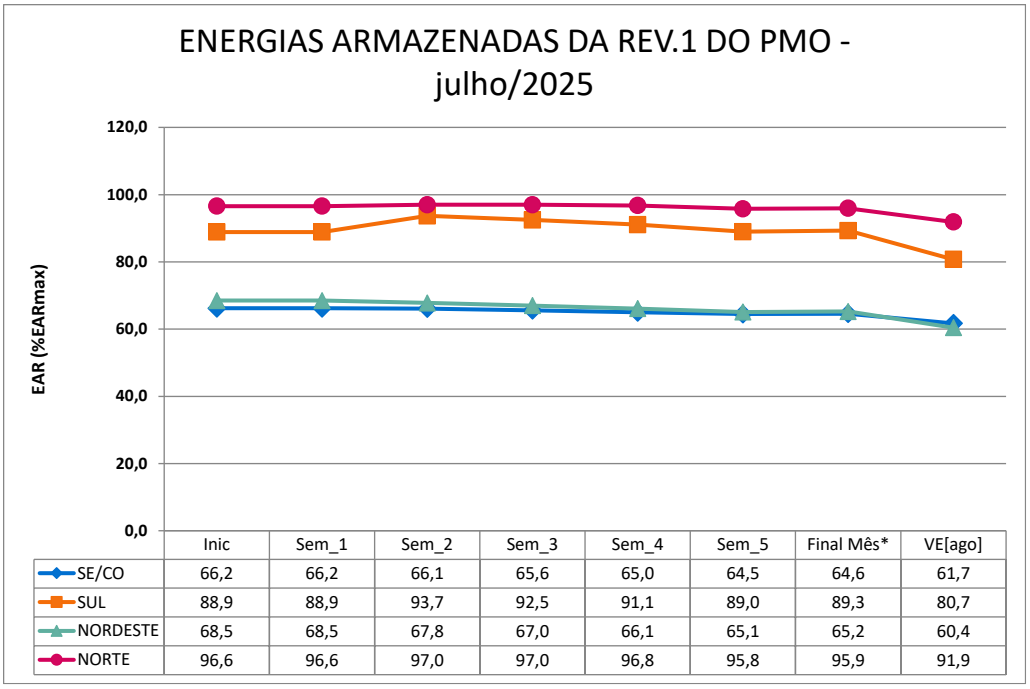


| | Inic | Sem_1 | Sem_2 | Sem_3 | Sem_4 | Sem_5 | Final Mês* | VE[ago] |
|---|---|---|---|---|---|---|---|---|
| SE/CO | 66,2 | 66,2 | 66,1 | 65,6 | 65,0 | 64,5 | 64,6 | 61,7 |
| SUL | 88,9 | 88,9 | 93,7 | 92,5 | 91,1 | 89,0 | 89,3 | 80,7 |
| NORDESTE | 68,5 | 68,5 | 67,8 | 67,0 | 66,1 | 65,1 | 65,2 | 60,4 |
| NORTE | 96,6 | 96,6 | 97,0 | 97,0 | 96,8 | 95,8 | 95,9 | 91,9 |

Os armazenamentos da figura anterior estão expressos em percentual da Energia Armazenável Máxima de cada subsistema, que são mostradas na tabela a seguir.

Tabela 8 – Energia Armazenável Máxima por subsistema no PMO de Julho/2025

| ENERGIA ARMAZENÁVEL MÁXIMA (MWmed) | | |
|---|---|---|
| Subsistema | julho | agosto |
| SE/CO | 205.582 | 205.582 |
| S | 20.458 | 20.458 |
| NE | 51.718 | 51.718 |
| N | 15.297 | 15.689 |

O conteúdo desta publicação foi produzido pelo ONS com base em dados e informações de conhecimento público. É de responsabilidade exclusiva dos agentes e demais interessados a obtenção de outros dados e informações, a realização de análises, estudos e avaliações para fins de tomada de decisões, definição de estratégias de atuação, assunção de compromissos e obrigações e quaisquer outras finalidades, em qualquer tempo e sob qualquer condição. É proibida a reprodução ou utilização total ou parcial do presente sem a identificação da fonte.

## 5. GERAÇÃO TÉRMICA

A Figura 19 apresenta, para cada subsistema do SIN, o despacho térmico por modalidade indicado pelo Decomp para esta semana operativa.

Figura 19 – Geração térmica para a próxima semana operativa

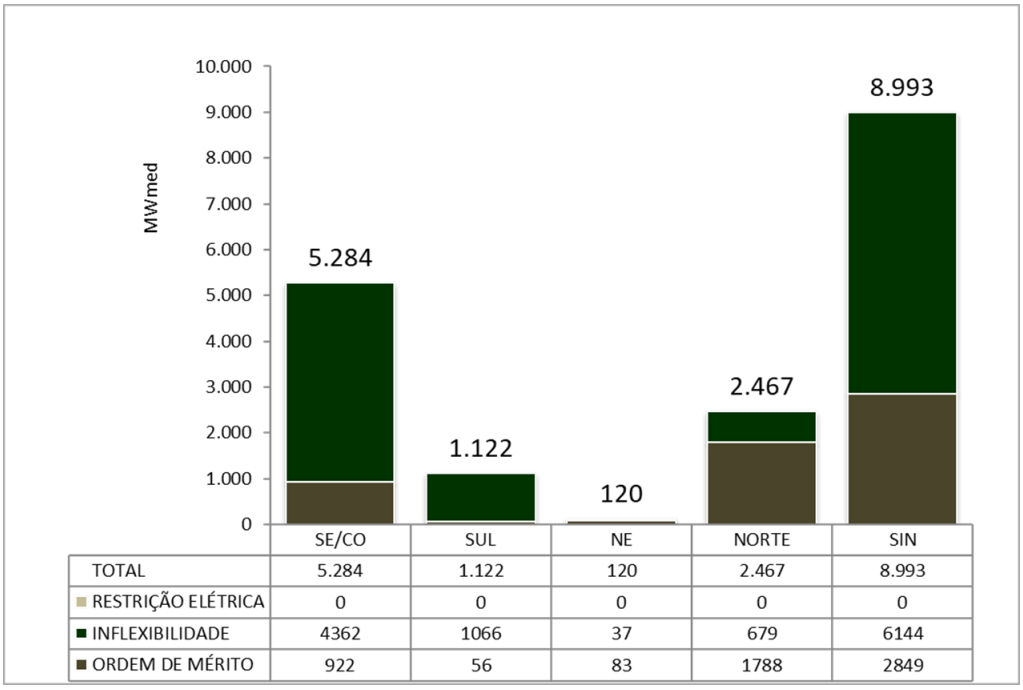


Na tabela abaixo segue a Indicação de despacho antecipado por ordem de mérito de custo para a semana de 06/09/2025 a 12/09/2025.

Tabela 9 – UTEs com contrato de combustível GNL

| UTE | | | Benefício (R$/MWh) | | | Despacho antecipado por mérito | | |
|---|---|---|---|---|---|---|---|---|
| Nome | Código | CVU (R$/MWh) | Carga Pesada | Carga Média | Carga Leve | Carga Pesada | Carga Média | Carga Leve |
| SANTA CRUZ | 86 | 230,82 | 292,54 | 284,68 | 275,98 | Sim | Sim | Sim |
| LUIZORMELO | 15 | 349,22 | 292,54 | 284,68 | 275,98 | Não | Não | Não |
| PSERGIPE I | 224 | 314,65 | 290,05 | 284,05 | 275,98 | Não | Não | Não |

Assim sendo, há indicação de despacho antecipado por ordem de mérito de custo para a UTE Santa Cruz para a semana de 06/09/2025 a 12/09/2025 nos três patamares de carga.

Para as UTEs Luiz O. R. Melo e Porto Sergipe I, não há indicação de despacho antecipado.

O conteúdo desta publicação foi produzido pelo ONS com base em dados e informações de conhecimento público. É de responsabilidade exclusiva dos agentes e demais interessados a obtenção de outros dados e informações, a realização de análises, estudos e avaliações para fins de tomada de decisões, definição de estratégias de atuação, assunção de compromissos e obrigações e quaisquer outras finalidades, em qualquer tempo e sob qualquer condição. É proibida a reprodução ou utilização total ou parcial do presente sem a identificação da fonte.

## 6. RESUMO DOS RESULTADOS DO PMO

As figuras a seguir apresentam um resumo dos resultados da Revisão 1 de Julho/2025, com informações da Energia Natural Afluente (ENA), da Energia Armazenada (EAR) e do Custo Marginal de Operação (CMO) nos subsistemas do Sistema Interligado Nacional (SIN). São apresentados os valores semanais observados e previstos e o valor esperado dos cenários gerados para o mês de agosto/2025.

Figura 20 – Resumo de julho/2025 para o Subsistema Sudeste/Centro-Oeste

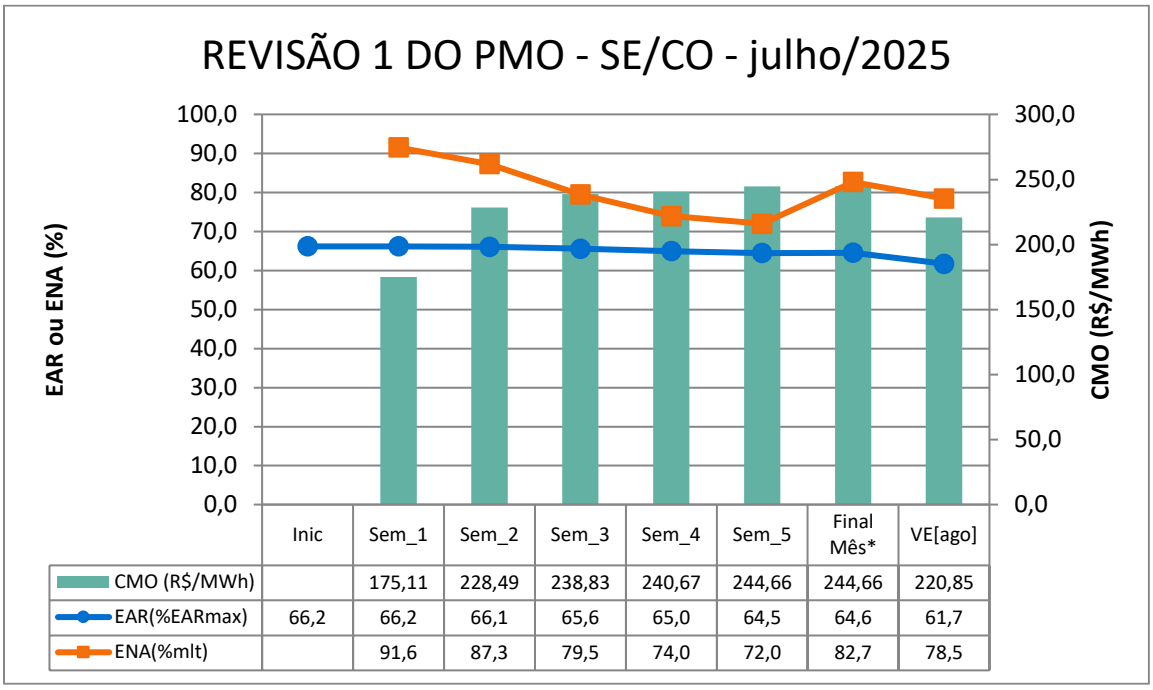


| | Inic | Sem_1 | Sem_2 | Sem_3 | Sem_4 | Sem_5 | Final Mês* | VE[ago] |
|---|---|---|---|---|---|---|---|---|
| CMO (R$/MWh) | | 175,11 | 228,49 | 238,83 | 240,67 | 244,66 | 244,66 | 220,85 |
| EAR(%EARmax) | 66,2 | 66,2 | 66,1 | 65,6 | 65,0 | 64,5 | 64,6 | 61,7 |
| ENA(%mlt) | | 91,6 | 87,3 | 79,5 | 74,0 | 72,0 | 82,7 | 78,5 |

Figura 21 – Resumo de julho/2025 para o Subsistema Sul

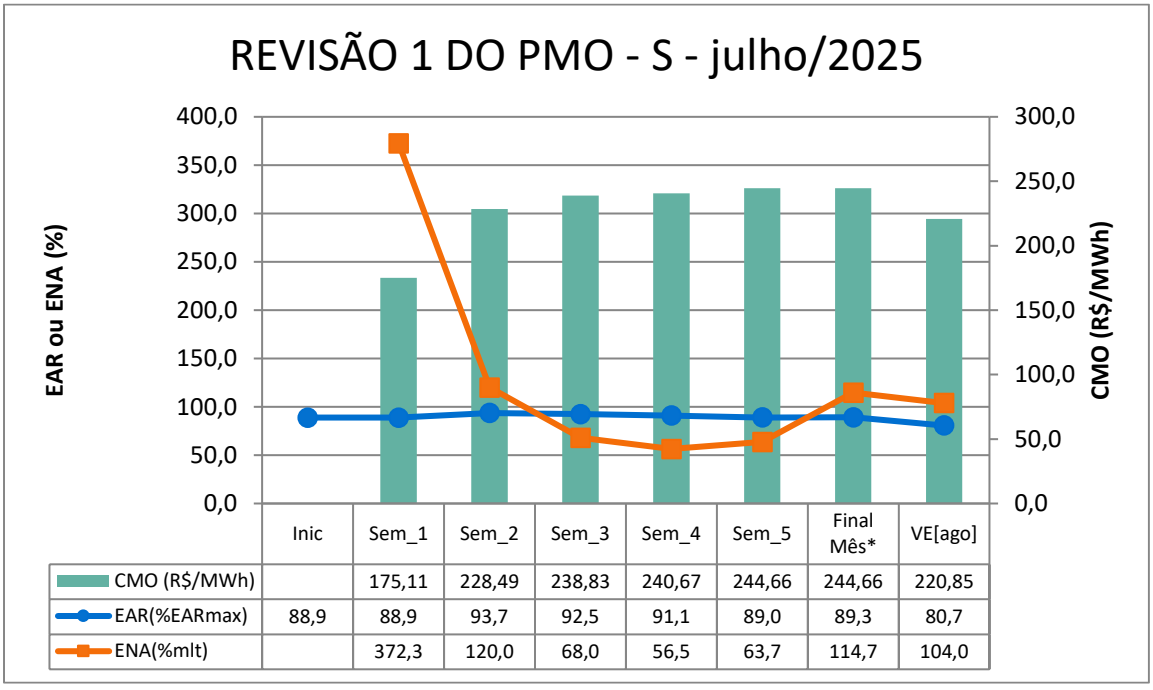


| | Inic | Sem_1 | Sem_2 | Sem_3 | Sem_4 | Sem_5 | Final Mês* | VE[ago] |
|---|---|---|---|---|---|---|---|---|
| CMO (R$/MWh) | | 175,11 | 228,49 | 238,83 | 240,67 | 244,66 | 244,66 | 220,85 |
| EAR(%EARmax) | 88,9 | 88,9 | 93,7 | 92,5 | 91,1 | 89,0 | 89,3 | 80,7 |
| ENA(%mlt) | | 372,3 | 120,0 | 68,0 | 56,5 | 63,7 | 114,7 | 104,0 |

O conteúdo desta publicação foi produzido pelo ONS com base em dados e informações de conhecimento público. É de responsabilidade exclusiva dos agentes e demais interessados a obtenção de outros dados e informações, a realização de análises, estudos e avaliações para fins de tomada de decisões, definição de estratégias de atuação, assunção de compromissos e obrigações e quaisquer outras finalidades, em qualquer tempo e sob qualquer condição. É proibida a reprodução ou utilização total ou parcial do presente sem a identificação da fonte.

Figura 22 – Resumo de julho/2025 para o Subsistema Nordeste

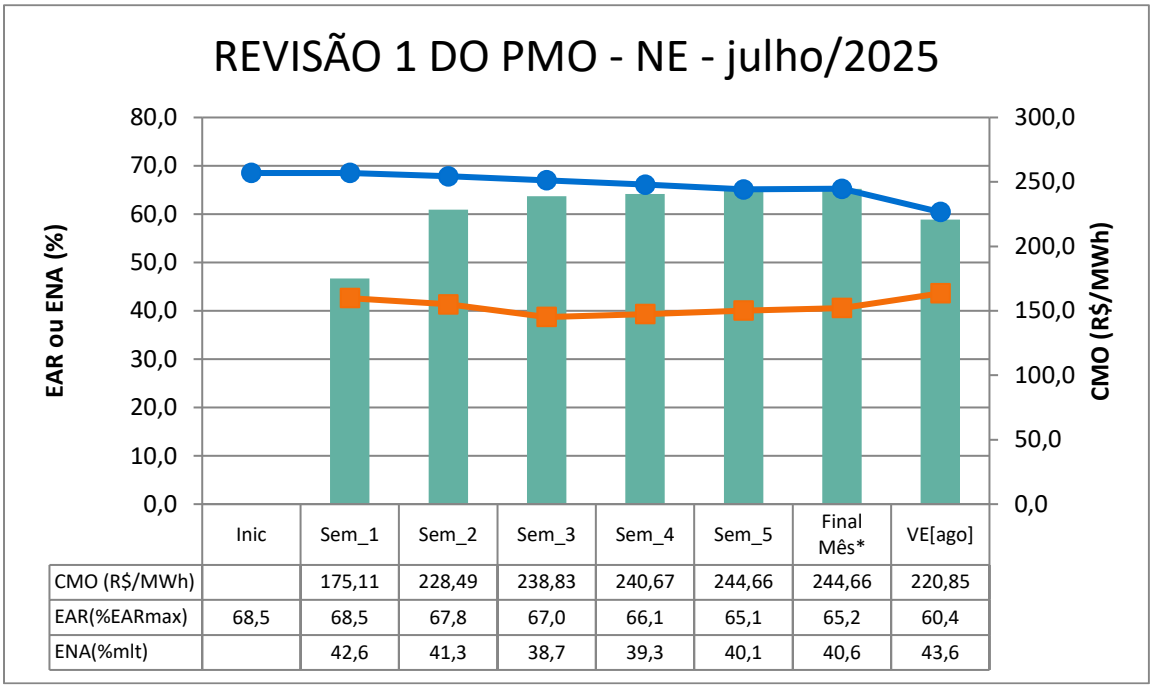


| | Inic | Sem_1 | Sem_2 | Sem_3 | Sem_4 | Sem_5 | Final Mês* | VE[ago] |
|---|---|---|---|---|---|---|---|---|
| CMO (R$/MWh) | | 175,11 | 228,49 | 238,83 | 240,67 | 244,66 | 244,66 | 220,85 |
| EAR(%EARmax) | 68,5 | 68,5 | 67,8 | 67,0 | 66,1 | 65,1 | 65,2 | 60,4 |
| ENA(%mlt) | | 42,6 | 41,3 | 38,7 | 39,3 | 40,1 | 40,6 | 43,6 |

Figura 23 – Resumo de julho/2025 para o Subsistema Norte

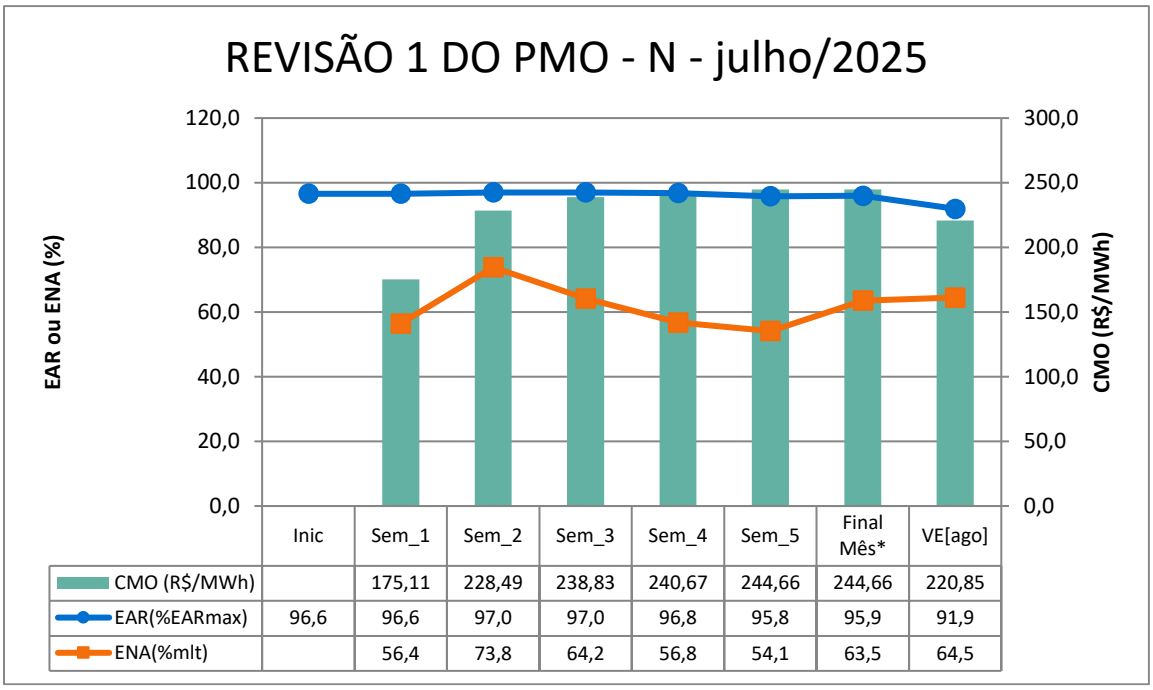


| | Inic | Sem_1 | Sem_2 | Sem_3 | Sem_4 | Sem_5 | Final Mês* | VE[ago] |
|---|---|---|---|---|---|---|---|---|
| CMO (R$/MWh) | | 175,11 | 228,49 | 238,83 | 240,67 | 244,66 | 244,66 | 220,85 |
| EAR(%EARmax) | 96,6 | 96,6 | 97,0 | 97,0 | 96,8 | 95,8 | 95,9 | 91,9 |
| ENA(%mlt) | | 56,4 | 73,8 | 64,2 | 56,8 | 54,1 | 63,5 | 64,5 |

O conteúdo desta publicação foi produzido pelo ONS com base em dados e informações de conhecimento público. É de responsabilidade exclusiva dos agentes e demais interessados a obtenção de outros dados e informações, a realização de análises, estudos e avaliações para fins de tomada de decisões, definição de estratégias de atuação, assunção de compromissos e obrigações e quaisquer outras finalidades, em qualquer tempo e sob qualquer condição. É proibida a reprodução ou utilização total ou parcial do presente sem a identificação da fonte.

## 7. ARMAZENAMENTOS OPERATIVOS

Para uma melhor avaliação de diversos cenários hidrometeorológicos, notadamente, aqueles de curto prazo e suas influências nas previsões de vazões nos subsistemas, os resultados desta revisão do PMO contemplam cenários de afluências visando melhor representar a ocorrência de precipitação e, consequentemente, seus efeitos sobre as afluências e armazenamentos.

Apresentamos a seguir as correspondentes energias naturais afluentes e os resultados obtidos com a aplicação do cenário de afluência utilizado no estudo.

Tabela 10 – Previsão de ENA do caso de valor esperado das previsões de afluência

| Subsistema | ENERGIAS NATURAIS AFLUENTES | | | |
|---|---|---|---|---|
| | Previsão Semanal | | Previsão Mensal | |
| | (MWmed) | %MLT | (MWmed) | %MLT |
| SE/CO | 22.662 | 89 | 21.159 | 83 |
| Sul | 13.146 | 120 | 12.569 | 115 |
| Nordeste | 1.547 | 41 | 1.519 | 41 |
| Norte | 3.699 | 71 | 3.330 | 64 |

Tabela 11 – Previsão de %EARmáx para o final do mês

| Subsistema | % EARmáx 04/07 | % EARmáx - 31/07 |
|---|---|---|
| | NÍVEL INICIAL | NÍVEL PMO |
| SE/CO | 66,2 | 64,6 |
| Sul | 88,9 | 89,3 |
| Nordeste | 68,5 | 65,2 |
| Norte | 96,6 | 95,9 |

O conteúdo desta publicação foi produzido pelo ONS com base em dados e informações de conhecimento público. É de responsabilidade exclusiva dos agentes e demais interessados a obtenção de outros dados e informações, a realização de análises, estudos e avaliações para fins de tomada de decisões, definição de estratégias de atuação, assunção de compromissos e obrigações e quaisquer outras finalidades, em qualquer tempo e sob qualquer condição. É proibida a reprodução ou utilização total ou parcial do presente sem a identificação da fonte.

## 8. RESERVATÓRIOS EQUIVALENTES DE ENERGIA

A seguir são apresentadas as previsões de Energia Natural Afluente para a próxima semana operativa e para o mês de julho, bem como as previsões de Energia Armazenada nos Reservatórios Equivalentes de Energia – REE, desta revisão do PMO de Julho de 2025.

Tabela 12 – Previsão de ENA por REE

| Valor Esperado das Energias Naturais Afluentes | | | | |
|---|---|---|---|---|
| REE | Previsão Semanal | | Previsão Mensal | |
| | 05/07/2025 a 11/07/2025 | | jul-25 | |
| | (MWmed) | %MLT | (MWmed) | %MLT |
| Sudeste | 1.895 | 64 | 1.815 | 62 |
| Madeira | 6.255 | 163 | 5.273 | 137 |
| Teles Pires | 975 | 96 | 903 | 89 |
| Itaipu | 2.749 | 89 | 2.634 | 85 |
| Paraná | 8.956 | 72 | 8.620 | 69 |
| Paranapanema | 1.503 | 66 | 1.450 | 64 |
| Sul | 6.867 | 113 | 7.350 | 121 |
| Iguaçu | 6.279 | 129 | 5.219 | 107 |
| Nordeste | 1.547 | 41 | 1.519 | 41 |
| Norte | 1.538 | 60 | 1.421 | 55 |
| Belo Monte | 1.403 | 85 | 1.138 | 69 |
| Manaus | 929 | 90 | 853 | 83 |

Tabela 13 – Previsão de %EARmáx por REE

| % Energia Armazenável Máxima | | |
|---|---|---|
| REE | Previsão Semanal | Previsão Mensal |
| | 11-jul | 31-jul |
| | (%EARmáx) | (%EARmáx) |
| Sudeste | 69,0 | 66,9 |
| Madeira | 79,8 | 75,3 |
| Teles Pires | 71,0 | 71,0 |
| Itaipu | 100,0 | 100,0 |
| Paraná | 64,9 | 63,2 |
| Paranapanema | 65,7 | 67,9 |
| Sul | 91,7 | 84,3 |
| Iguaçu | 95,6 | 94,2 |
| Nordeste | 67,8 | 65,2 |
| Norte | 97,2 | 96,0 |
| Belo Monte | 100,0 | 100,0 |
| Manaus | 92,1 | 96,4 |

O conteúdo desta publicação foi produzido pelo ONS com base em dados e informações de conhecimento público. É de responsabilidade exclusiva dos agentes e demais interessados a obtenção de outros dados e informações, a realização de análises, estudos e avaliações para fins de tomada de decisões, definição de estratégias de atuação, assunção de compromissos e obrigações e quaisquer outras finalidades, em qualquer tempo e sob qualquer condição. É proibida a reprodução ou utilização total ou parcial do presente sem a identificação da fonte.

## 9. DESPACHO TÉRMICO POR MODALIDADE, PATAMAR DE CARGA E USINA

Nas tabelas abaixo, a diferenciação entre geração por inflexibilidade e por ordem de mérito tem caráter informativo, com o objetivo de detalhar a informação de inflexibilidade enviada pelos respectivos agentes para esta revisão do PMO. Ressalta-se que nas etapas de Programação Diária e Tempo Real, o montante despachado nas usinas termelétricas indicadas por ordem de mérito é plenamente intitulado como ordem de mérito.

**REGIÃO SUDESTE/CENTRO-OESTE**

| Térmicas Potência (MW) | Combustível | CVU (R$/MWh) | Inflexibilidade | | | Ordem de Mérito | | | Total Mérito e INFL. | | | Razão Elétrica | | | Total UTE | | |
|---|---|---|---|---|---|---|---|---|---|---|---|---|---|---|---|---|---|
| | | | P | M | L | P | M | L | P | M | L | P | M | L | P | M | L |
| ATLAN_CSA (255) | Resíduos | 0,00 | 72,7 | 72,7 | 72,7 | | | | 72,7 | 72,7 | 72,7 | | | | 72,7 | 72,7 | 72,7 |
| DAIA (44) | Diesel | --- | | | | | | | | | | | | | | | |
| TNORTE 2 (349) | Óleo | --- | | | | | | | | | | | | | | | |
| W.ARJONA O (177) | Diesel | --- | | | | | | | | | | | | | | | |
| XAVANTES (54) | Diesel | --- | | | | | | | | | | | | | | | |
| ANGRA 2 (1350) | Nuclear | 20,12 | 1350,0 | 1350,0 | 1350,0 | 0,0 | 0,0 | 0,0 | 1350,0 | 1350,0 | 1350,0 | | | | 1350,0 | 1350,0 | 1350,0 |
| ANGRA 1 (640) | Nuclear | 31,17 | 512,0 | 433,0 | 263,0 | 0,0 | 0,0 | 0,0 | 512,0 | 433,0 | 263,0 | | | | 512,0 | 433,0 | 263,0 |
| M.AZUL (566) | Gás | 136,49 | | | | 565,5 | 565,5 | 565,5 | 565,5 | 565,5 | 565,5 | | | | 565,5 | 565,5 | 565,5 |
| O.PINTADA (50) | Biomassa | 145,52 | | | | 50,0 | 50,0 | 50,0 | 50,0 | 50,0 | 50,0 | | | | 50,0 | 50,0 | 50,0 |
| UTE STA VI (41) | Biomassa | 157,20 | 18,0 | 18,0 | 18,0 | 23,0 | 23,0 | 23,0 | 41,0 | 41,0 | 41,0 | | | | 41,0 | 41,0 | 41,0 |
| BAIXADA FL (530) | Gás | 227,09 | | | | 530,0 | 530,0 | | 530,0 | 530,0 | | | | | 530,0 | 530,0 | 0,0 |
| SANTA CRUZ (500) | GNL | 230,82 | | | | | | | | | | | | | | | |
| ATLANTICO (235) | Resíduos | 259,71 | 218,7 | 218,7 | 218,7 | | | | 218,7 | 218,7 | 218,7 | | | | 218,7 | 218,7 | 218,7 |
| ST.CRUZ 34 (436) | Óleo | 310,41 | | | | | | | | | | | | | | | |
| LUIZORMELO (204) | GNL | 349,22 | | | | | | | | | | | | | | | |
| CUBATAO (216) | Gás | 430,27 | 200,0 | 200,0 | 200,0 | | | | 200,0 | 200,0 | 200,0 | | | | 200,0 | 200,0 | 200,0 |
| UTE GNA I (1338) | Gás | 440,62 | | | | | | | | | | | | | | | |
| PIRAT.12 O (200) | Gás | 470,34 | | | | | | | | | | | | | | | |
| UTE GNA II (1673) | Gás | 560,12 | 1672,0 | 1672,0 | 1672,0 | | | | 1672,0 | 1672,0 | 1672,0 | | | | 1672,0 | 1672,0 | 1672,0 |
| IBIRITE (235) | Gás | 808,21 | | | | | | | | | | | | | | | |
| NORTEFLU (826) | Gás | 852,74 | 118,0 | 118,0 | 118,0 | | | | 118,0 | 118,0 | 118,0 | | | | 118,0 | 118,0 | 118,0 |
| KARKEY 013 (259) | Gás | 876,64 | 31,0 | 31,0 | 31,0 | | | | 31,0 | 31,0 | 31,0 | | | | 31,0 | 31,0 | 31,0 |
| KARKEY 019 (116) | Gás | 876,64 | | | | | | | | | | | | | | | |
| TERMORIO (989) | Gás | 899,73 | 300,0 | 300,0 | 300,0 | | | | 300,0 | 300,0 | 300,0 | | | | 300,0 | 300,0 | 300,0 |
| T.LAGOAS (350) | Gás | 909,79 | | | | | | | | | | | | | | | |
| T.MACAE (922) | Gás | 957,69 | | | | | | | | | | | | | | | |
| PORSUD II (78) | Gás | 1029,18 | | | | | | | | | | | | | | | |
| PORSUD I (116) | Gás | 1029,46 | | | | | | | | | | | | | | | |
| CUIABA CC (529) | Gás | 1046,82 | | | | | | | | | | | | | | | |
| PAULINIA (16) | Gás | 1252,64 | 15,7 | 15,7 | 15,7 | | | | 15,7 | 15,7 | 15,7 | | | | 15,7 | 15,7 | 15,7 |
| SEROPEDICA (360) | Gás | 1253,19 | | | | | | | | | | | | | | | |
| J.FORA (87) | Gás | 1262,76 | | | | | | | | | | | | | | | |
| LORM_PCS (36) | Gás | 1274,48 | | | | | | | | | | | | | | | |
| POVOACAO I (75) | Gás | 1274,48 | | | | | | | | | | | | | | | |
| VIANA I (37) | Gás | 1274,48 | | | | | | | | | | | | | | | |
| PALMEIR_GO (176) | Diesel | 1438,78 | | | | | | | | | | | | | | | |
| W.ARJONA (177) | Gás | 1461,52 | | | | | | | | | | | | | | | |
| NPIRATINGA (572) | Gás | 1523,76 | | | | | | | | | | | | | | | |
| VIANA (175) | Óleo | 1734,64 | | | | | | | | | | | | | | | |
| TOTAL SE/CO (14989) | | | 4508,1 | 4429,1 | 4259,1 | 1168,5 | 1168,5 | 638,5 | 5676,6 | 5597,6 | 4897,6 | 0,0 | 0,0 | 0,0 | 5676,6 | 5597,6 | 4897,6 |

**REGIÃO SUL**

| Térmicas Potência (MW) | Combustível | | Inflexibilidade | | | Ordem de Mérito | | | Total Mérito e INFL. | | | Razão Elétrica | | | Total UTE | | |
|---|---|---|---|---|---|---|---|---|---|---|---|---|---|---|---|---|---|
| | | | P | M | L | P | M | L | P | M | L | P | M | L | P | M | L |
| PAMPA SUL (345) | Carvão | 101,20 | 297,1 | 297,1 | 297,1 | 47,9 | 47,9 | 47,9 | 345,0 | 345,0 | 345,0 | | | | 345,0 | 345,0 | 345,0 |
| SAO SEPE (8) | Biomassa | 113,53 | | | | 8,0 | 8,0 | 8,0 | 8,0 | 8,0 | 8,0 | | | | 8,0 | 8,0 | 8,0 |
| FIGUEIRA (20) | Carvão | 330,64 | | | | | | | | | | | | | | | |
| J.LACER. C (330) | Carvão | 341,04 | 300,0 | 300,0 | 300,0 | | | | 300,0 | 300,0 | 300,0 | | | | 300,0 | 300,0 | 300,0 |
| J.LACER. B (220) | Carvão | 397,24 | 110,0 | 110,0 | 110,0 | | | | 110,0 | 110,0 | 110,0 | | | | 110,0 | 110,0 | 110,0 |
| J.LAC. A2 (110) | Carvão | 406,63 | 55,0 | 55,0 | 55,0 | | | | 55,0 | 55,0 | 55,0 | | | | 55,0 | 55,0 | 55,0 |
| J.LAC. A1 (80) | Carvão | 475,13 | 40,0 | 40,0 | 40,0 | | | | 40,0 | 40,0 | 40,0 | | | | 40,0 | 40,0 | 40,0 |
| CANDIOTA_3 (350) | Carvão | 524,78 | 260,0 | 260,0 | 260,0 | | | | 260,0 | 260,0 | 260,0 | | | | 260,0 | 260,0 | 260,0 |
| URUGUAIANA (640) | Gás | 774,41 | | | | | | | | | | | | | | | |
| B.BONITA I (10) | Gás | 778,35 | 3,7 | 3,7 | 3,7 | | | | 3,7 | 3,7 | 3,7 | | | | 3,7 | 3,7 | 3,7 |
| ARAUCARIA (484) | Gás | 1131,31 | | | | | | | | | | | | | | | |
| CANOAS (249) | Gás | 1407,91 | | | | | | | | | | | | | | | |
| TOTAL SUL (2846) | | | 1065,8 | 1065,8 | 1065,8 | 55,9 | 55,9 | 55,9 | 1121,7 | 1121,7 | 1121,7 | 0,0 | 0,0 | 0,0 | 1121,7 | 1121,7 | 1121,7 |

O conteúdo desta publicação foi produzido pelo ONS com base em dados e informações de conhecimento público. É de responsabilidade exclusiva dos agentes e demais interessados a obtenção de outros dados e informações, a realização de análises, estudos e avaliações para fins de tomada de decisões, definição de estratégias de atuação, assunção de compromissos e obrigações e quaisquer outras finalidades, em qualquer tempo e sob qualquer condição. É proibida a reprodução ou utilização total ou parcial do presente sem a identificação da fonte.

**REGIÃO NORDESTE**

| Térmicas Potência (MW) | Combustível | | Inflexibilidade | | | Ordem de Mérito | | | Total Mérito e INFL. | | | Razão Elétrica | | | Total UTE | | |
|---|---|---|---|---|---|---|---|---|---|---|---|---|---|---|---|---|---|
| | | | P | M | L | P | M | L | P | M | L | P | M | L | P | M | L |
| CAMPINA_GR (169) | Óleo | --- | | | | | | | | | | | | | | | |
| GLOBAL I (149) | Óleo | --- | | | | | | | | | | | | | | | |
| GLOBAL II (149) | Óleo | --- | | | | | | | | | | | | | | | |
| MARACANAU (168) | Óleo | --- | | | | | | | | | | | | | | | |
| PETROLINA (136) | Óleo | --- | | | | | | | | | | | | | | | |
| POTIGUAR (53) | Diesel | --- | | | | | | | | | | | | | | | |
| POTIGUAR_3 (66) | Diesel | --- | | | | | | | | | | | | | | | |
| TERMOCABO (50) | Óleo | --- | | | | | | | | | | | | | | | |
| TERMONE (171) | Óleo | --- | | | | | | | | | | | | | | | |
| TERMOPB (171) | Óleo | --- | | | | | | | | | | | | | | | |
| ERB CANDEI (17) | Biomassa | 113,61 | 3,5 | 3,5 | 3,5 | 8,5 | 8,5 | 8,5 | 12,0 | 12,0 | 12,0 | | | | 12,0 | 12,0 | 12,0 |
| PROSP_I (28) | Gás | 214,28 | | | | 18,7 | 18,7 | 18,7 | 18,7 | 18,7 | 18,7 | | | | 18,7 | 18,7 | 18,7 |
| PROSP_III (56) | Gás | 218,33 | | | | 56,0 | 56,0 | 56,0 | 56,0 | 56,0 | 56,0 | | | | 56,0 | 56,0 | 56,0 |
| P.PECEM1 (720) | Carvão | 311,05 | | | | | | | | | | | | | | | |
| PSERGIPE I (1593) | GNL | 314,65 | 40,0 | 35,0 | 30,0 | | | | 40,0 | 35,0 | 30,0 | | | | 40,0 | 35,0 | 30,0 |
| P.PECEM2 (365) | Carvão | 320,42 | | | | | | | | | | | | | | | |
| PROSP_II (37) | Gás | 328,17 | | | | | | | | | | | | | | | |
| VALE ACU (110) | Gás | 450,86 | | | | | | | | | | | | | | | |
| T.BAHIA (186) | Gás | 663,53 | | | | | | | | | | | | | | | |
| PERNAMBU_3 (201) | Óleo | 819,54 | | | | | | | | | | | | | | | |
| TERMOPE (550) | Gás | 930,84 | | | | | | | | | | | | | | | |
| SUAPE II (381) | Óleo | 969,93 | | | | | | | | | | | | | | | |
| TERMOCEARA (223) | Gás | 1938,83 | | | | | | | | | | | | | | | |
| C.MURICY 2 (144) | Óleo | 2319,04 | | | | | | | | | | | | | | | |
| PECEM 2 (144) | Óleo | 2343,17 | | | | | | | | | | | | | | | |
| TOTAL NE (5749) | | | 43,5 | 38,5 | 33,5 | 83,2 | 83,2 | 83,2 | 126,7 | 121,7 | 116,7 | 0,0 | 0,0 | 0,0 | 126,7 | 121,7 | 116,7 |

**REGIÃO NORTE**

| Térmicas Potência (MW) | Combustível | | Inflexibilidade | | | Ordem de Mérito | | | Total Mérito e INFL. | | | Razão Elétrica | | | Total UTE | | |
|---|---|---|---|---|---|---|---|---|---|---|---|---|---|---|---|---|---|
| | | | P | M | L | P | M | L | P | M | L | P | M | L | P | M | L |
| MARANHAO3 (519) | Gás | 110,91 | | | | 501,5 | 500,6 | 513,6 | 501,5 | 500,6 | 513,6 | | | | 501,5 | 500,6 | 513,6 |
| APARECIDA (166) | Gás | 114,11 | 75,0 | 75,0 | 75,0 | 73,0 | 73,0 | 73,0 | 148,0 | 148,0 | 148,0 | | | | 148,0 | 148,0 | 148,0 |
| JARAQUI (75) | Gás | 114,11 | 29,0 | 29,0 | 29,0 | 34,0 | 34,0 | 34,0 | 63,0 | 63,0 | 63,0 | | | | 63,0 | 63,0 | 63,0 |
| PIRARUCU (73) | Gás | 114,11 | 35,0 | 35,0 | 35,0 | 32,0 | 32,0 | 32,0 | 67,0 | 67,0 | 67,0 | | | | 67,0 | 67,0 | 67,0 |
| PORAQUE (85) | Gás | 114,11 | 28,0 | 28,0 | 28,0 | 39,0 | 39,0 | 39,0 | 67,0 | 67,0 | 67,0 | | | | 67,0 | 67,0 | 67,0 |
| TAMBAQUI (93) | Gás | 114,11 | 33,0 | 33,0 | 33,0 | 30,0 | 30,0 | 30,0 | 63,0 | 63,0 | 63,0 | | | | 63,0 | 63,0 | 63,0 |
| TUCUNARE (73) | Gás | 114,11 | 35,0 | 35,0 | 35,0 | 29,0 | 29,0 | 29,0 | 64,0 | 64,0 | 64,0 | | | | 64,0 | 64,0 | 64,0 |
| UTE MAUA 3 (591) | Gás | 114,11 | 264,0 | 264,0 | 264,0 | 326,8 | 326,8 | 326,8 | 590,8 | 590,8 | 590,8 | | | | 590,8 | 590,8 | 590,8 |
| MARANHAO V (338) | Gás | 213,68 | | | | 330,0 | 329,6 | 335,3 | 330,0 | 329,6 | 335,3 | | | | 330,0 | 329,6 | 335,3 |
| MARANHAOIV (338) | Gás | 213,68 | | | | 330,0 | 329,6 | 335,3 | 330,0 | 329,6 | 335,3 | | | | 330,0 | 329,6 | 335,3 |
| PARNAIBA_V (386) | Vapor | 233,55 | | | | 356,1 | | | 356,1 | | | | | | 356,1 | 0,0 | 0,0 |
| N.VENECIA2 (270) | Gás | 294,56 | 180,0 | 180,0 | 180,0 | | | | 180,0 | 180,0 | 180,0 | | | | 180,0 | 180,0 | 180,0 |
| P. ITAQUI (360) | Carvão | 312,59 | | | | | | | | | | | | | | | |
| PARNAIB_IV (56) | Gás | 439,07 | | | | | | | | | | | | | | | |
| GERAMAR2 (166) | Óleo | 2007,32 | | | | | | | | | | | | | | | |
| GERAMAR1 (166) | Óleo | 2032,63 | | | | | | | | | | | | | | | |
| TOTAL NORTE (4045) | | | 679,0 | 679,0 | 679,0 | 2081,4 | 1723,6 | 1748,0 | 2760,4 | 2402,6 | 2427,0 | 0,0 | 0,0 | 0,0 | 2760,4 | 2402,6 | 2427,0 |

O conteúdo desta publicação foi produzido pelo ONS com base em dados e informações de conhecimento público. É de responsabilidade exclusiva dos agentes e demais interessados a obtenção de outros dados e informações, a realização de análises, estudos e avaliações para fins de tomada de decisões, definição de estratégias de atuação, assunção de compromissos e obrigações e quaisquer outras finalidades, em qualquer tempo e sob qualquer condição. É proibida a reprodução ou utilização total ou parcial do presente sem a identificação da fonte.