1. APRESENTAÇÃO

Na semana de 01/11 a 07/11/2025, houve elevada precipitação nas bacias dos rios Grande, Paranaíba, em pontos isolados da bacia do Tocantins, Xingu e Paranapanema e no trecho incremental a UHE Itaipu.

Na semana de 08/11 a 14/11/2025, deve ocorrer precipitação nas bacias dos rios Paranaíba, São Francisco, Tocantins, Xingu, Tapajós e Madeira.

Os valores médios semanais do Custo Marginal de Operação – CMO dos subsistemas do SIN sofreram as seguintes alterações em relação à semana anterior:

- SE/CO: de R$ 349,82/MWh para R$ 305,15/MWh
- Sul: de R$ 349,82/MWh para R$ 305,15/MWh
- Nordeste: de R$ 349,82/MWh para R$ 305,15/MWh
- Norte: de R$ 349,82/MWh para R$ 305,15/MWh

Desde o dia 01/01/2020, o despacho por ordem de mérito é indicado diariamente pelos resultados do modelo DESSEM. Assim, o despacho por ordem de mérito semanal, conforme publicado nesse documento, tem caráter apenas informativo. Da mesma forma, desde o dia 01/01/2021, a formação de preço deixou o formato semanal/patamar de carga e passou a ser horário, de acordo também com os resultados do modelo DESSEM.

2. NOTÍCIAS

Nos dias 27 e 28 de novembro será realizada a reunião de elaboração do PMO de Dezembro de 2025, com transmissão ao vivo através do site do ONS.

3. INFORMAÇÕES CONJUNTURAIS PARA ELABORAÇÃO DO PMO

3.1. Informações hidrometeorológicas

3.1.1. Condições antecedentes

A atuação de um sistema de baixa pressão na Região Sul no início da semana ocasionou totais elevados de precipitação na incremental a UHE Itaipu e em pontos isolados da bacia do rio Paranapanema. A atuação do sistema também favoreceu a ocorrência de precipitação nas bacias hidrográficas das Regiões Sudeste, Centro-Oeste e Norte, atingindo as bacias dos rios Grande, Paranaíba e pontos isolados do Tocantins e Xingu (Figura 1). O avanço rápido de uma frente fria no final da semana pelo litoral das Regiões Sul, Sudeste e do sul da Bahia manteve a condição de precipitação.

O conteúdo desta publicação foi produzido pelo ONS com base em dados e informações de conhecimento público. É de responsabilidade exclusiva dos agentes e demais interessados a obtenção de outros dados e informações, a realização de análises, estudos e avaliações para fins de tomada de decisões, definição de estratégias de atuação, assunção de compromissos e obrigações e quaisquer outras finalidades, em qualquer tempo e sob qualquer condição. É proibida a reprodução ou utilização total ou parcial do presente sem a identificação da fonte.

Figura 1 – Precipitação observada (mm) no período de 01/11 a 06/11/2025

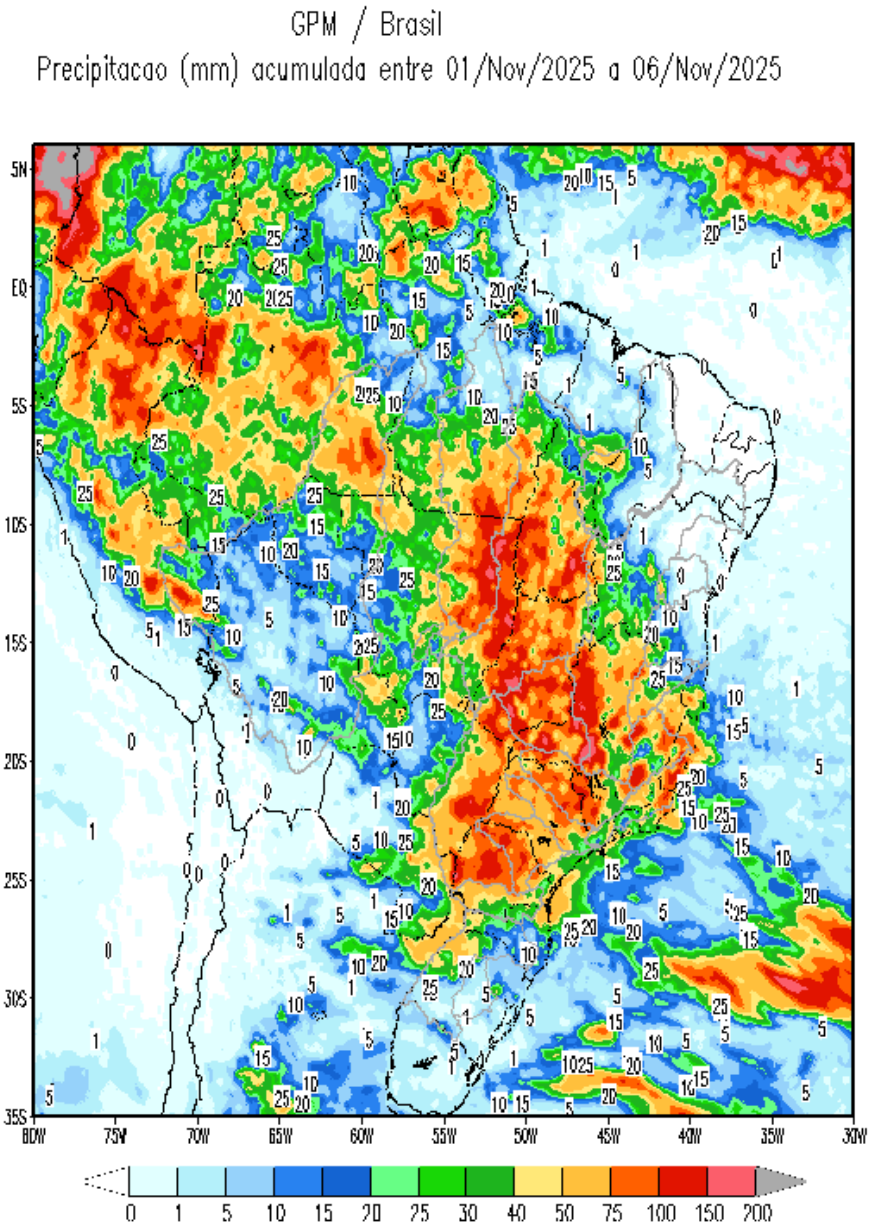

A **Tabela 1** apresenta as energias naturais afluentes das semanas recentes. São apresentados os valores verificados na semana 25/10/2025 a 31/10/2025 e os estimados para fechamento da semana de 01/11/2025 a 07/11/2025.

Tabela 1 – Tendência hidrológica da ENA da revisão 1 de novembro/2025

Rev.1 do PMO de novembro/2025 - ENAs				
Subsistema	25/10 a 31/10/2025		01/11 a 07/11/2025	
	MWmed	%MLT	MWmed	%MLT
SE/CO	15.947	67	22.393	71
S	9.216	67	10.170	105
NE	1.038	33	1.126	21
N	1.303	55	1.338	33

O conteúdo desta publicação foi produzido pelo ONS com base em dados e informações de conhecimento público. É de responsabilidade exclusiva dos agentes e demais interessados a obtenção de outros dados e informações, a realização de análises, estudos e avaliações para fins de tomada de decisões, definição de estratégias de atuação, assunção de compromissos e obrigações e quaisquer outras finalidades, em qualquer tempo e sob qualquer condição. É proibida a reprodução ou utilização total ou parcial do presente sem a identificação da fonte.

3.1.2. Previsão para a próxima semana

O avanço de duas frentes frias, a primeira no início da semana pela Região Sudeste e litoral da Bahia e a segunda pelo Sul e Sudeste, ocasiona precipitação nas bacias hidrográficas dessas localidades, no Paranaíba, São Francisco, Tocantins, Xingu, Tapajós e Madeira (Figura 2).

Figura 2 - Precipitação acumulada prevista pelo modelo ECMWF - período de 08/11 a 14/11/2025

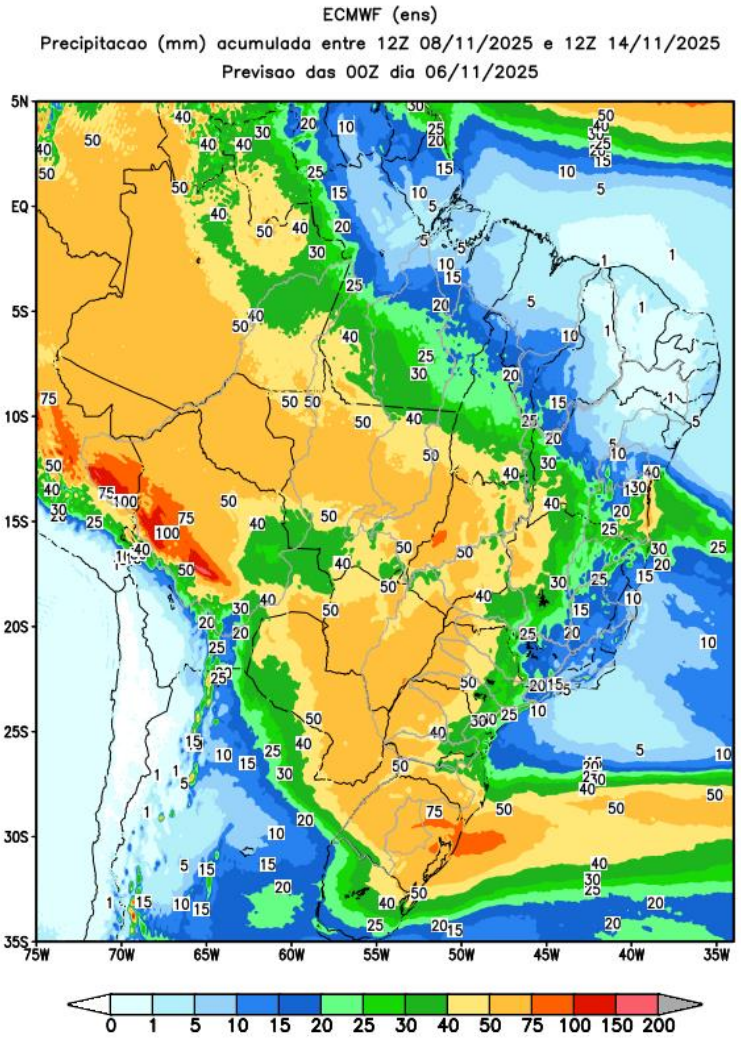

Tabela 2 – Previsão de ENAs da revisão 1 de novembro/2025

Revisão 1 do PMO de novembro/2025 - ENAs previstas				
Subsistema	08/11 a 14/11/2025		Mês de novembro	
	MWmed	%MLT	MWmed	%MLT
SE/CO	26.218	83	25.644	82
S	9.755	100	7.926	82
NE	1.343	26	1.909	36
N	2.510	62	3.232	80

O conteúdo desta publicação foi produzido pelo ONS com base em dados e informações de conhecimento público. É de responsabilidade exclusiva dos agentes e demais interessados a obtenção de outros dados e informações, a realização de análises, estudos e avaliações para fins de tomada de decisões, definição de estratégias de atuação, assunção de compromissos e obrigações e quaisquer outras finalidades, em qualquer tempo e sob qualquer condição. É proibida a reprodução ou utilização total ou parcial do presente sem a identificação da fonte.

As figuras a seguir ilustram as ENAs semanais verificadas e previstas para o PMO e para a revisão 1 do PMO de novembro/2025.

Figura 3 - Energias Naturais Afluentes ao Subsistema Sudeste/Centro-Oeste do PMO e da revisão 1 do PMO de novembro/2025

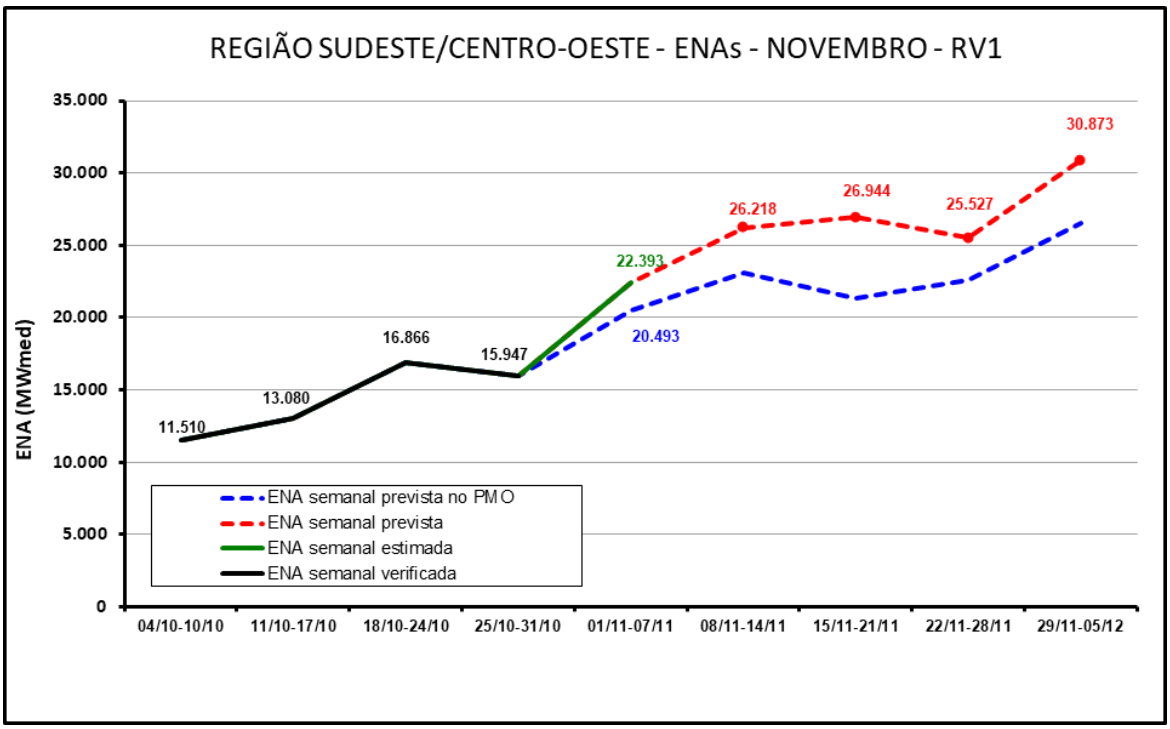

Figura 4 - Energias Naturais Afluentes ao Subsistema Sul do PMO e da revisão 1 do PMO de novembro/2025

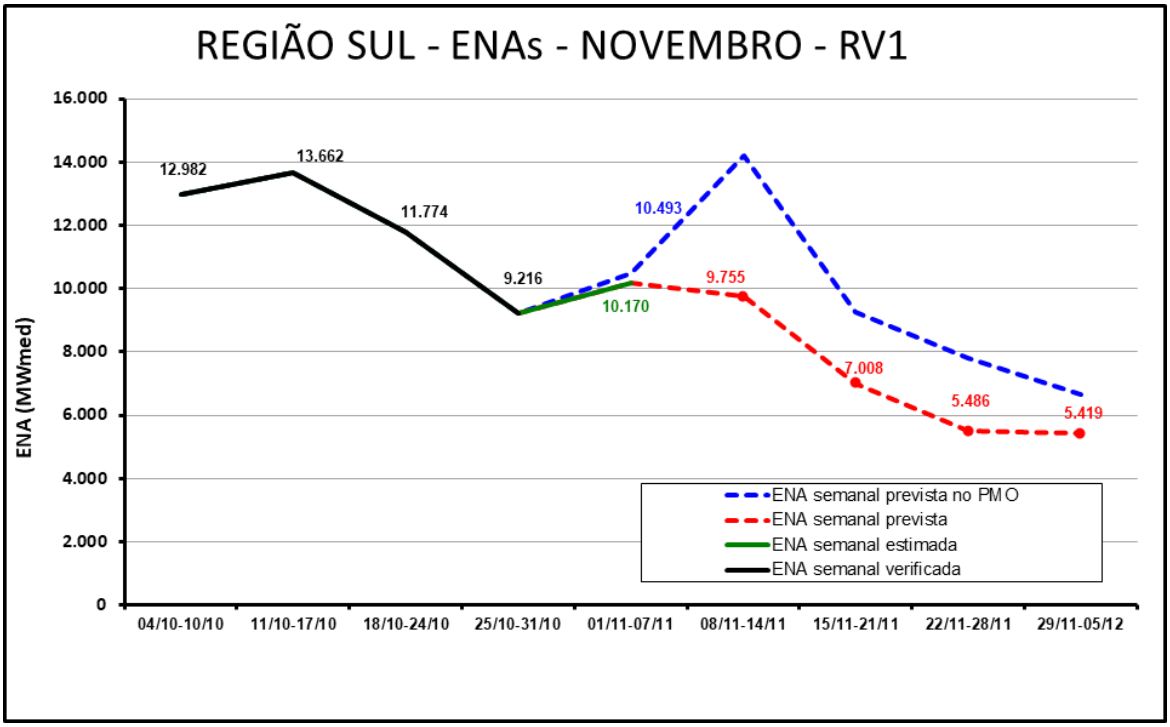

O conteúdo desta publicação foi produzido pelo ONS com base em dados e informações de conhecimento público. É de responsabilidade exclusiva dos agentes e demais interessados a obtenção de outros dados e informações, a realização de análises, estudos e avaliações para fins de tomada de decisões, definição de estratégias de atuação, assunção de compromissos e obrigações e quaisquer outras finalidades, em qualquer tempo e sob qualquer condição. É proibida a reprodução ou utilização total ou parcial do presente sem a identificação da fonte.

Figura 5 - Energias Naturais Afluentes ao Subsistema Nordeste do PMO e da revisão 1 do PMO de novembro/2025

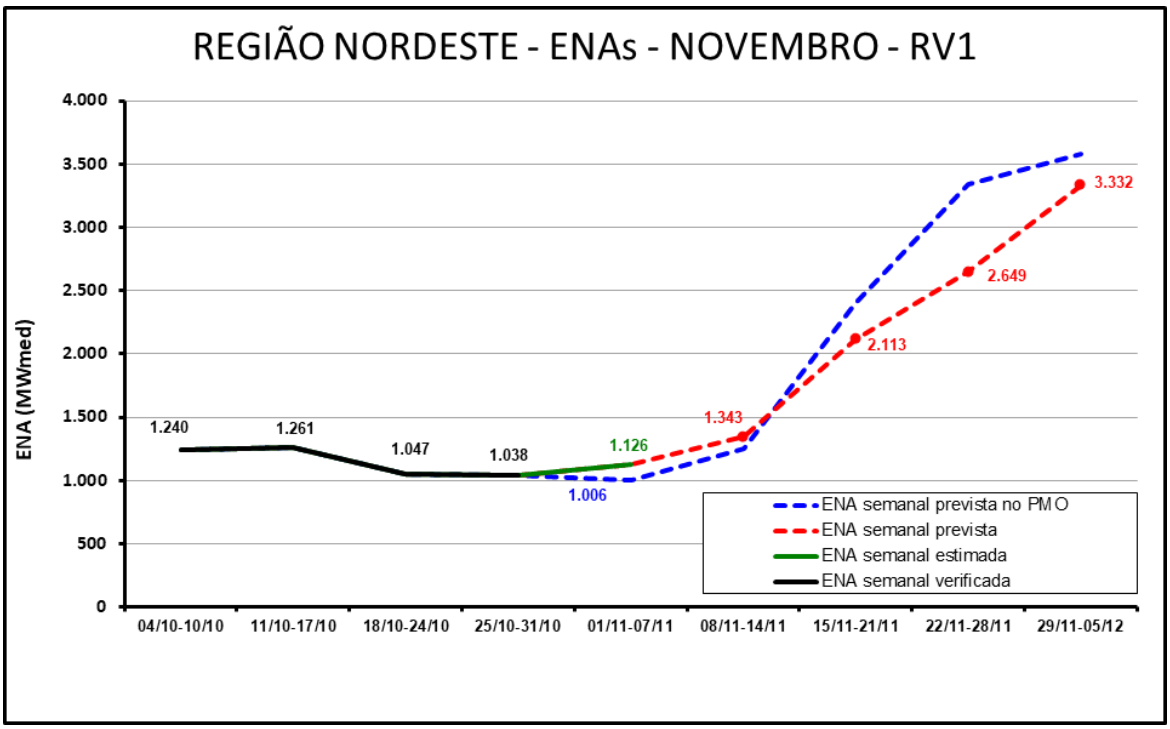

Figura 6 - Energias Naturais Afluentes ao Subsistema Norte do PMO e da revisão 1 do PMO de novembro/2025

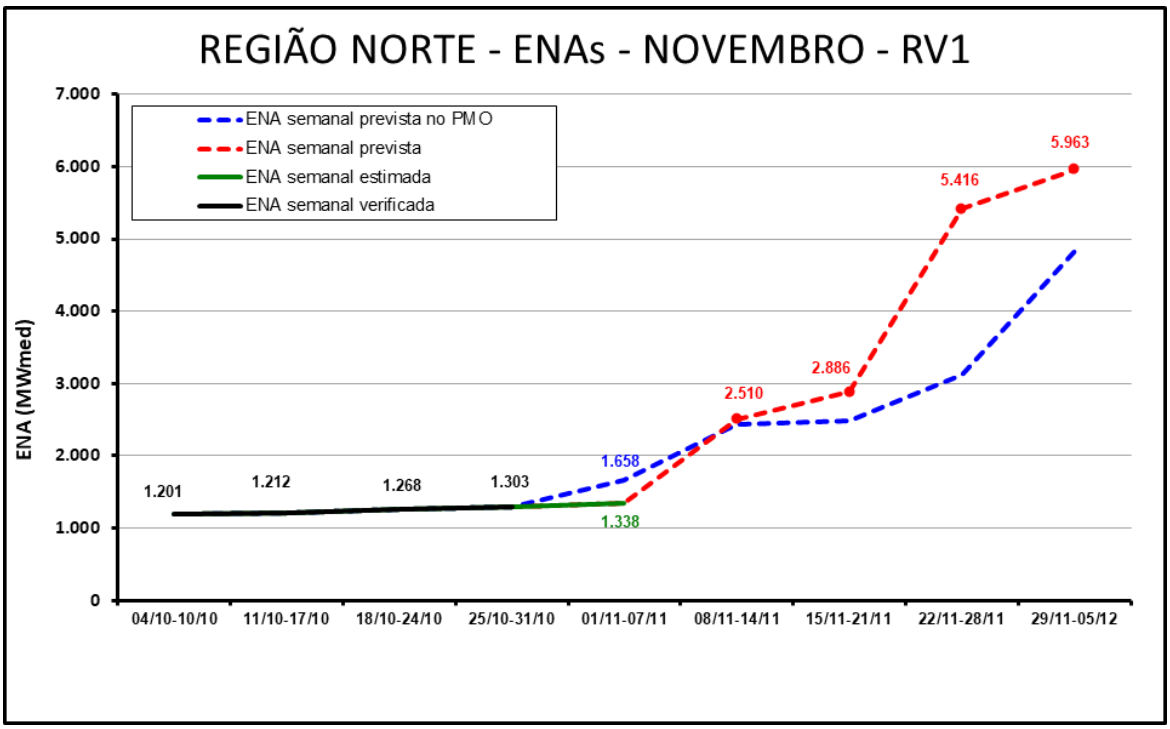

O conteúdo desta publicação foi produzido pelo ONS com base em dados e informações de conhecimento público. É de responsabilidade exclusiva dos agentes e demais interessados a obtenção de outros dados e informações, a realização de análises, estudos e avaliações para fins de tomada de decisões, definição de estratégias de atuação, assunção de compromissos e obrigações e quaisquer outras finalidades, em qualquer tempo e sob qualquer condição. É proibida a reprodução ou utilização total ou parcial do presente sem a identificação da fonte.

3.1.3. Cenários de ENAs para a Revisão 1 de Outubro/2025

As figuras a seguir apresentam as características dos cenários de energias naturais afluentes gerados na revisão 1 de novembro/2025, para acoplamento com a FCF do mês de dezembro/2025. São mostradas, para os quatro subsistemas, as amplitudes e as Funções de Distribuição Acumulada dos cenários de ENA, comparativamente com os valores considerados para o PMO de novembro/2025.

Figura 7 - Amplitude dos Cenários de ENA para o Subsistema Sudeste, em %MLT, para a revisão 1 de novembro/2025

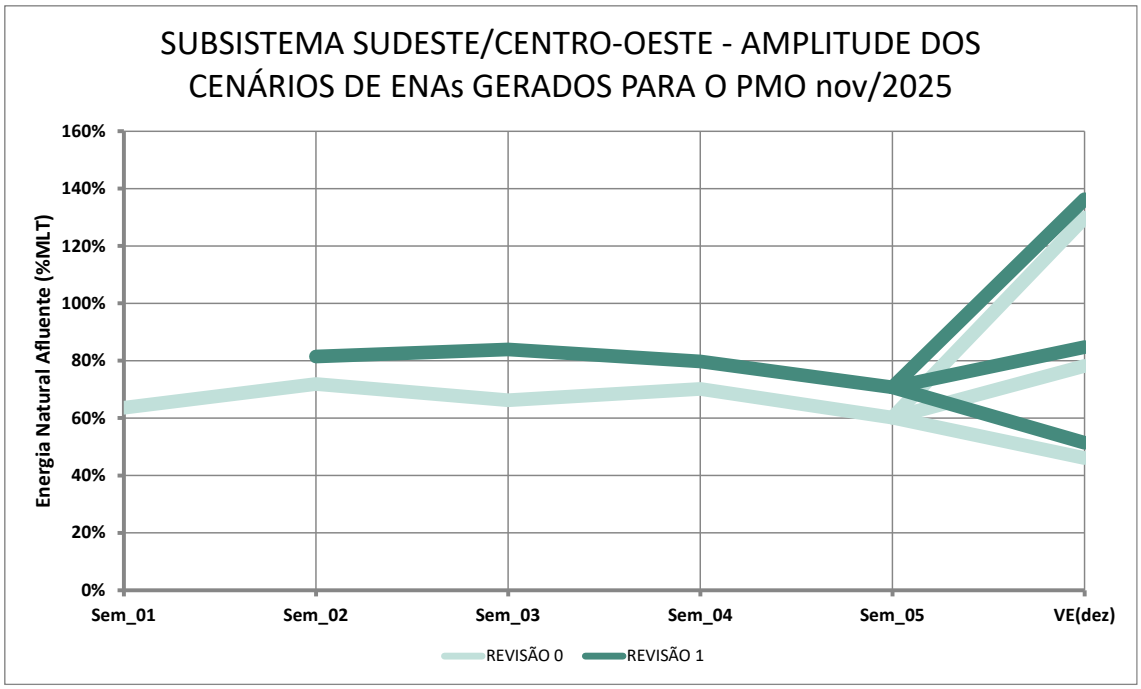

Figura 8 - Função de Distribuição Acumulada dos Cenários para o Subsistema Sudeste para a revisão 1 de novembro/2025

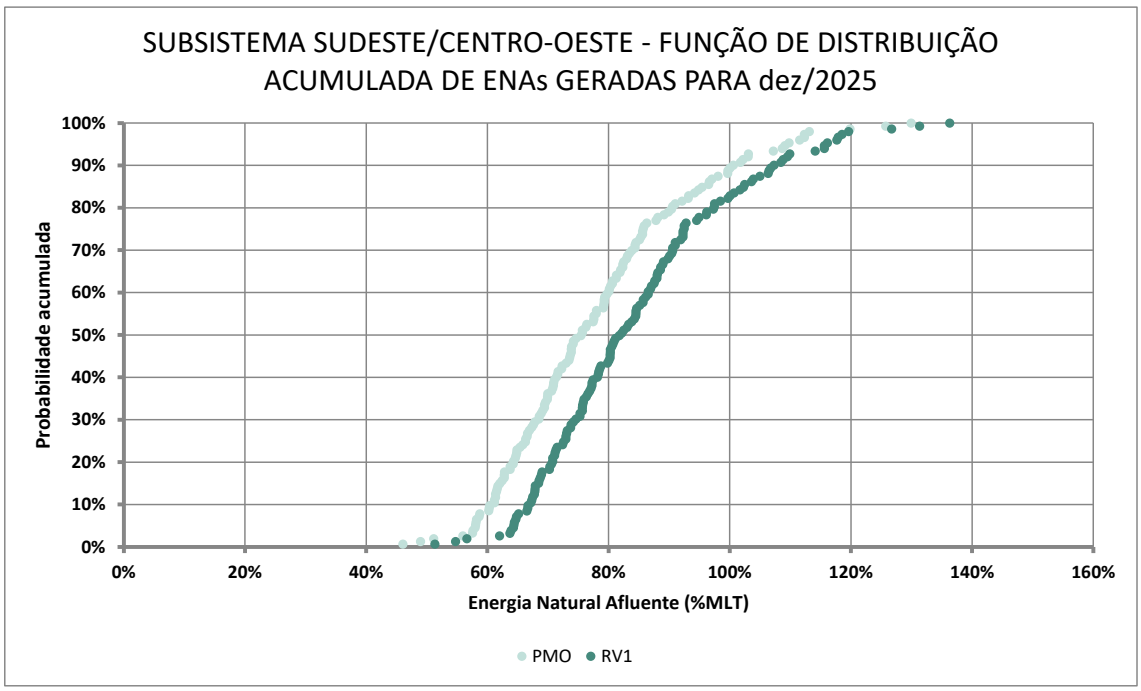

O conteúdo desta publicação foi produzido pelo ONS com base em dados e informações de conhecimento público. É de responsabilidade exclusiva dos agentes e demais interessados a obtenção de outros dados e informações, a realização de análises, estudos e avaliações para fins de tomada de decisões, definição de estratégias de atuação, assunção de compromissos e obrigações e quaisquer outras finalidades, em qualquer tempo e sob qualquer condição. É proibida a reprodução ou utilização total ou parcial do presente sem a identificação da fonte.

Figura 9 - Amplitude dos Cenários de ENA para o Subsistema Sul, em %MLT, para a revisão 1 de novembro/2025

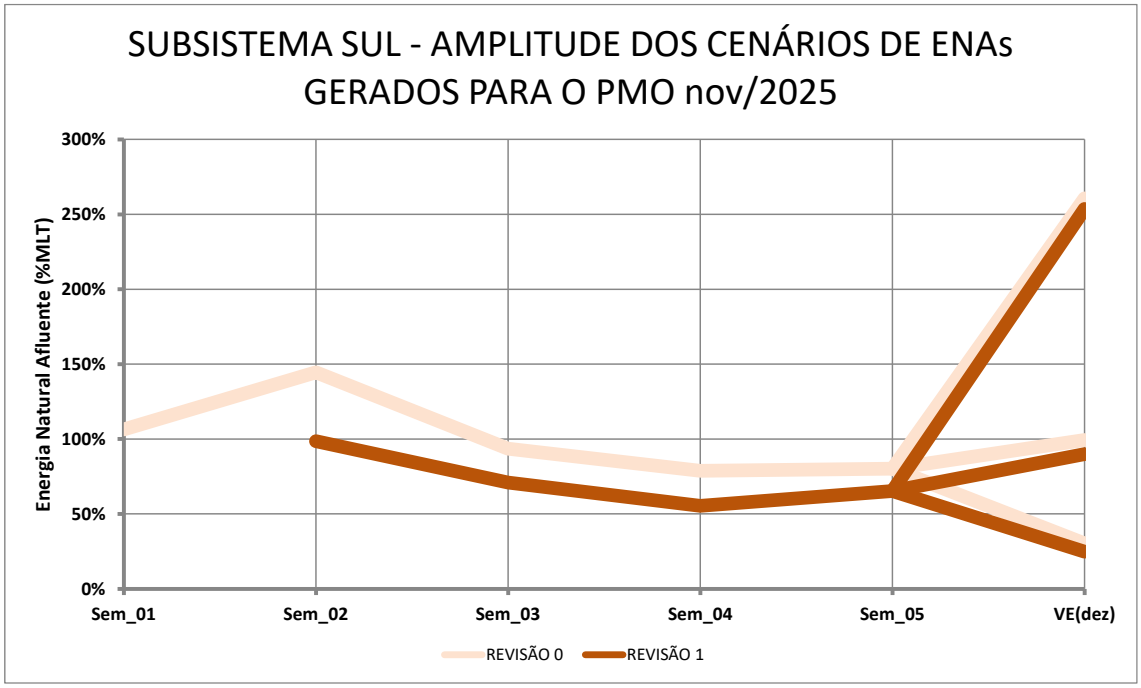

Figura 10 - Função de Distribuição Acumulada dos Cenários para o Subsistema Sul para a revisão 1 de novembro/2025

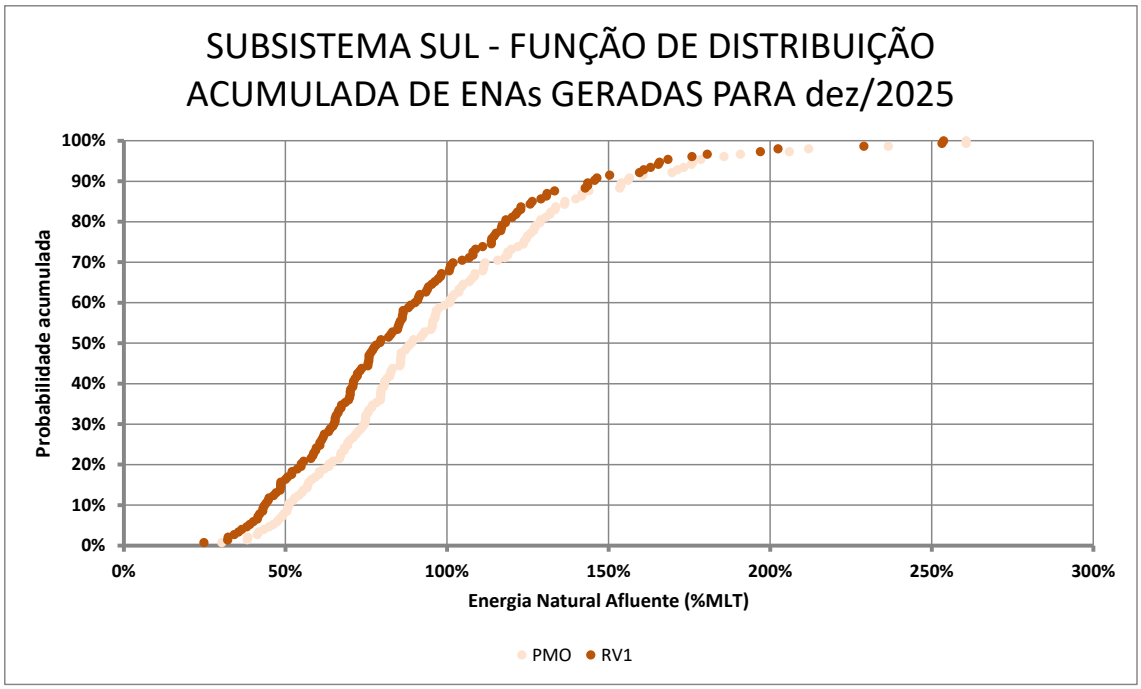

O conteúdo desta publicação foi produzido pelo ONS com base em dados e informações de conhecimento público. É de responsabilidade exclusiva dos agentes e demais interessados a obtenção de outros dados e informações, a realização de análises, estudos e avaliações para fins de tomada de decisões, definição de estratégias de atuação, assunção de compromissos e obrigações e quaisquer outras finalidades, em qualquer tempo e sob qualquer condição. É proibida a reprodução ou utilização total ou parcial do presente sem a identificação da fonte.

Figura 11 - Amplitude dos Cenários de ENA para o Subsistema Nordeste em %MLT, para a revisão 1 de novembro/2025

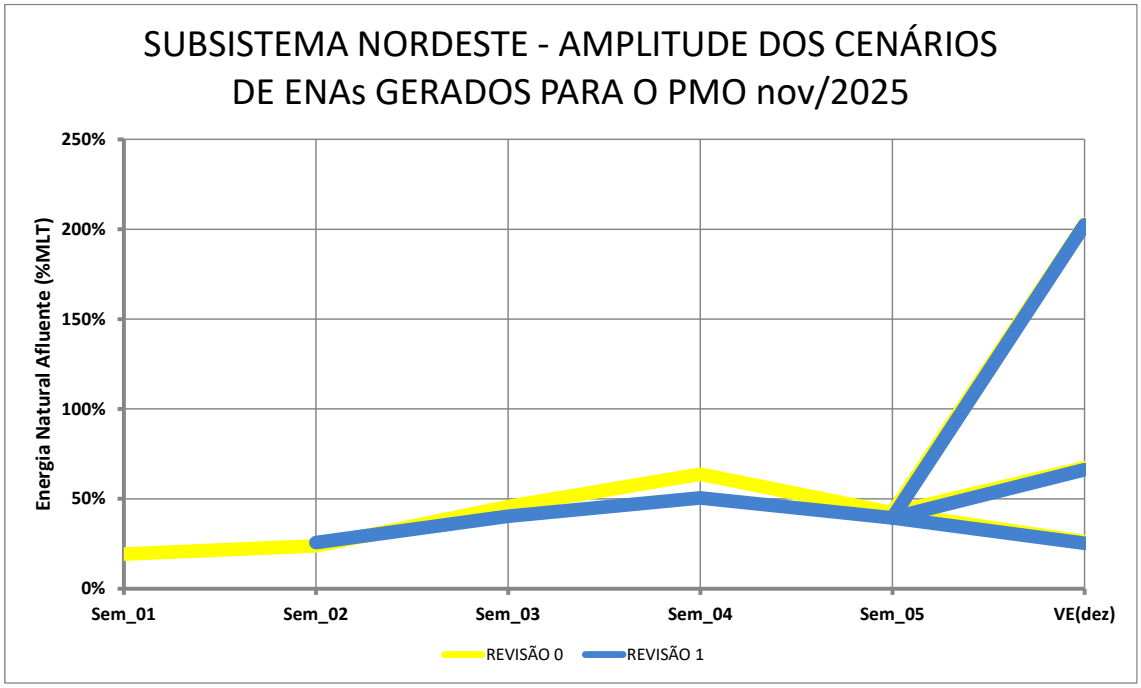

Figura 12 - Função de Distribuição Acumulada dos Cenários para o Subsistema Nordeste para a revisão 1 de novembro/2025

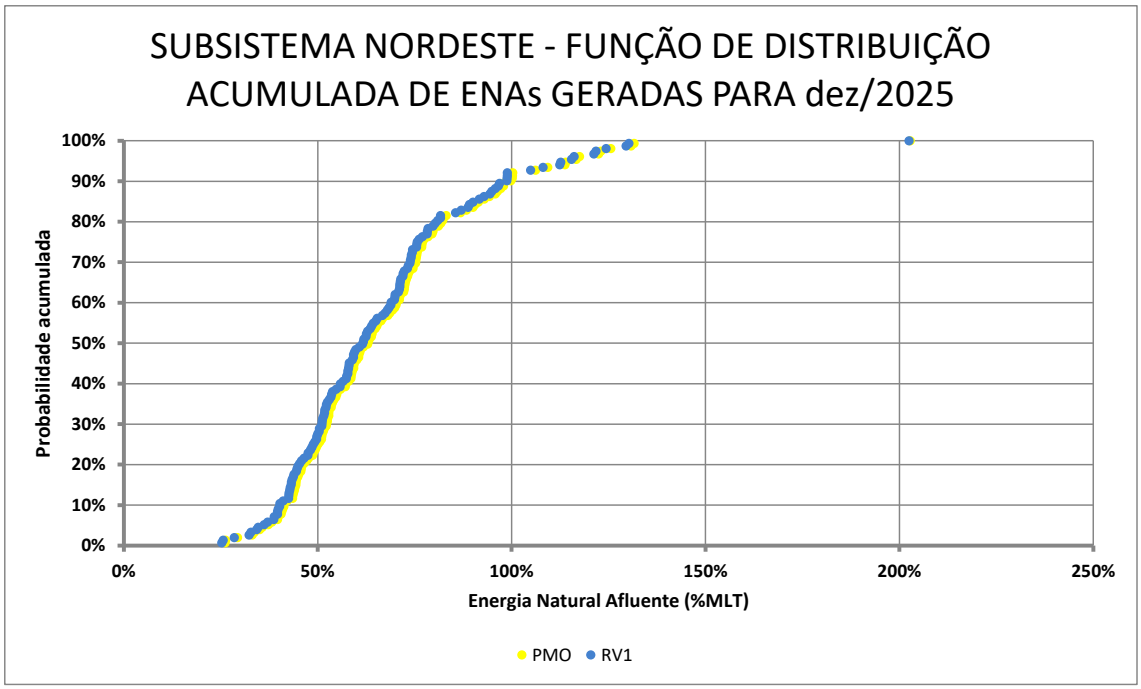

O conteúdo desta publicação foi produzido pelo ONS com base em dados e informações de conhecimento público. É de responsabilidade exclusiva dos agentes e demais interessados a obtenção de outros dados e informações, a realização de análises, estudos e avaliações para fins de tomada de decisões, definição de estratégias de atuação, assunção de compromissos e obrigações e quaisquer outras finalidades, em qualquer tempo e sob qualquer condição. É proibida a reprodução ou utilização total ou parcial do presente sem a identificação da fonte.

Figura 13 - Amplitude dos Cenários de ENA para o Subsistema Norte, em %MLT, para a revisão 1 de novembro/2025

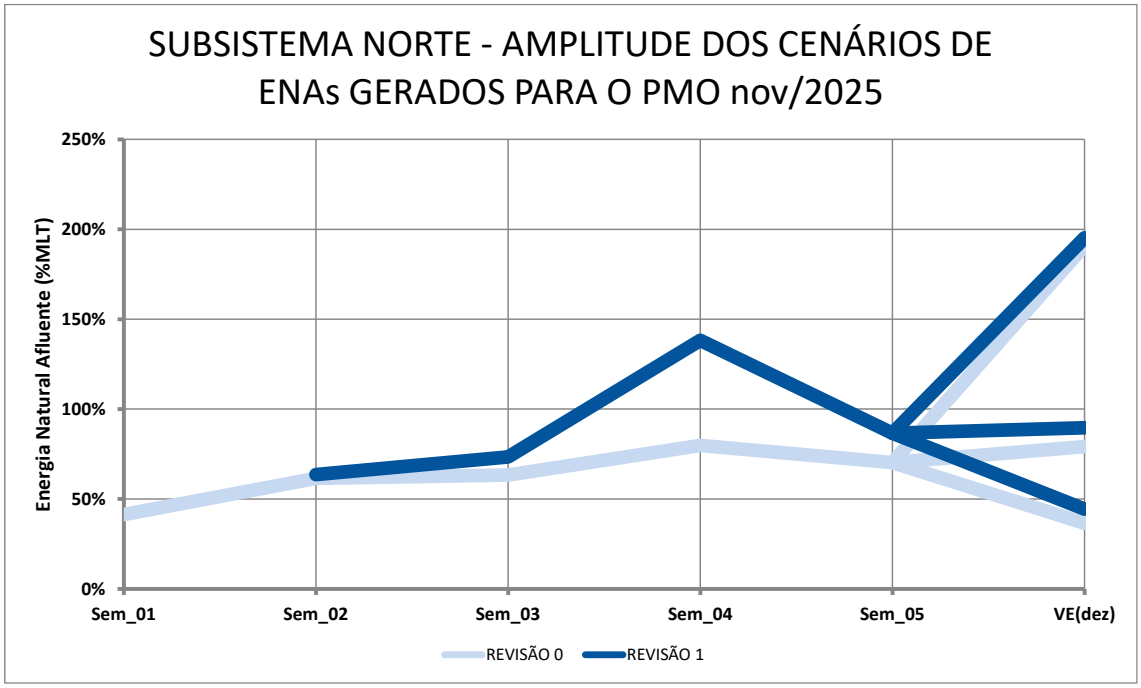

Figura 14 - Função de Distribuição Acumulada dos Cenários para o Subsistema Norte para a revisão 1 de novembro/2025

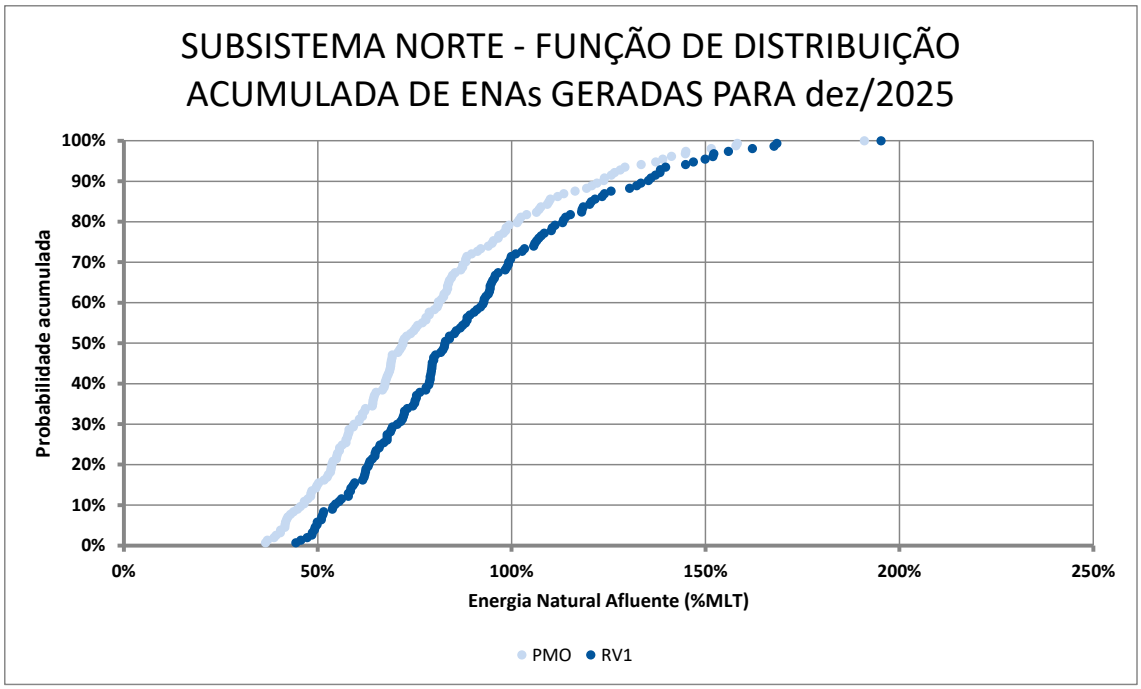

O conteúdo desta publicação foi produzido pelo ONS com base em dados e informações de conhecimento público. É de responsabilidade exclusiva dos agentes e demais interessados a obtenção de outros dados e informações, a realização de análises, estudos e avaliações para fins de tomada de decisões, definição de estratégias de atuação, assunção de compromissos e obrigações e quaisquer outras finalidades, em qualquer tempo e sob qualquer condição. É proibida a reprodução ou utilização total ou parcial do presente sem a identificação da fonte.

Os valores da MLT (Média de Longo Termo) das energias naturais afluentes para os meses de novembro/2025 e dezembro/2025 são apresentados na tabela a seguir.

Tabela 3 – MLT da ENA nos meses de novembro/2025 e dezembro/2025

MLT das ENAs (MWmed)		
Subsistema	**novembro**	**dezembro**
SE/CO	31.456	47.976
S	9.715	7.502
NE	5.246	9.747
N	4.035	8.350

3.2. Limites de Intercâmbio entre Subsistemas

Os limites elétricos de intercâmbio de energia entre subsistemas são de fundamental importância para o processo de otimização energética, sendo determinantes para a definição das políticas de operação e do CMO para cada subsistema. Estes limites são influenciados por intervenções na malha de transmissão, notadamente na primeira semana operativa. O diagrama a seguir ilustra os fluxos notáveis do SIN e os limites aplicados neste PMO.

Figura 15 – Interligações entre regiões

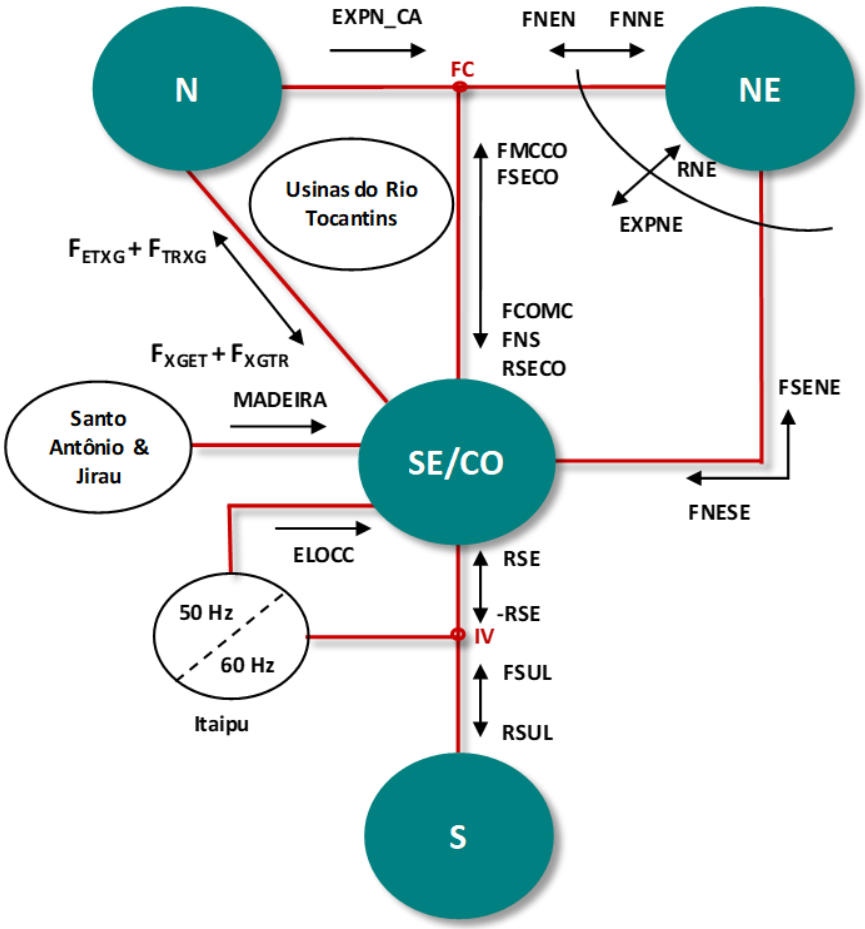

O conteúdo desta publicação foi produzido pelo ONS com base em dados e informações de conhecimento público. É de responsabilidade exclusiva dos agentes e demais interessados a obtenção de outros dados e informações, a realização de análises, estudos e avaliações para fins de tomada de decisões, definição de estratégias de atuação, assunção de compromissos e obrigações e quaisquer outras finalidades, em qualquer tempo e sob qualquer condição. É proibida a reprodução ou utilização total ou parcial do presente sem a identificação da fonte.

Tabela 4 – Limites considerados nesta semana operativa para intercâmbio de energia

Limites de Intercâmbio (MWmed)				
Fluxo	Patamar	08/11 a 14/11/2025		Demais Semanas
RNE	Pesada	11.000		11.000
	Média	11.000		11.000
	Leve	11.000		11.000
FNS	Pesada	5.200		5.200
	Média	5.200	(A) (B)	5.200
	Leve	**4.936**		5.000
FNNE	Pesada	7.800		7.800
	Média	7.800		7.800
	Leve	7.800		7.800
EXPORT. NE	Pesada	13.800		13.800
	Média	13.800		13.800
	Leve	13.800		13.800
FMCCO	Pesada	5.000		5.000
	Média	5.000		5.000
	Leve	5.000		5.000
FSENE	Pesada	6.000		6.000
	Média	6.000		6.000
	Leve	6.000		6.000
FNS + FNESE	Pesada	11.200		11.200
	Média	10.420	(A) (B)	10.420
	Leve	**11.136**		11.200
RSE	Pesada	10.200		10.200
	Média	10.200		10.200
	Leve	10.880		10.880
FORNEC. SUL	Pesada	7.000		7.000
	Média	7.000		7.000
	Leve	8.600		8.600

Limites de Intercâmbio (MWmed)				
Fluxo	Patamar	08/11 a 14/11/2025		Demais Semanas
RECEB. SUL	Pesada	**9.140**	(C)	11.500
	Média	**7.202**		7.850
	Leve	**9.932**		10.500
ELO CC 50 Hz	Pesada	3.132		3.132
	Média	3.132		3.132
	Leve	3.132		3.132
ITAIPU 60 Hz	Pesada	7.200		7.200
	Média	7.200		7.200
	Leve	7.200		7.200
EXP. N CA	Pesada	8.000		8.000
	Média	8.000		8.000
	Leve	8.000		8.000
FETXG + FTRXG	Pesada	4.200		4.200
	Média	1.000		1.000
	Leve	1.000		1.000
FXGET + FXGTR	Pesada	3.000		3.000
	Média	3.000		3.000
	Leve	3.000		3.000
FNESE	Pesada	**8.130**	(D) (E)	8.350
	Média	**7.868**		8.212
	Leve	**8.200**		8.350
FNEN	Pesada	**6.000**	(D)	6.200
	Média	**6.000**		6.200
	Leve	**6.000**		6.200
Ger_MADEIRA	Pesada	**4.197**	(C) (F) (G)	7.237
	Média	**4.481**		7.250
	Leve	**5.256**		7.264

(A) SGI 67.665-25
(B) SGI 67.176-25
(C) SGI 68.176-25
(D) SGI 32.474-25
(E) SGI 69.287-25
(F) SGI 70.118-25
(G) SGI 60.041-25

O conteúdo desta publicação foi produzido pelo ONS com base em dados e informações de conhecimento público. É de responsabilidade exclusiva dos agentes e demais interessados a obtenção de outros dados e informações, a realização de análises, estudos e avaliações para fins de tomada de decisões, definição de estratégias de atuação, assunção de compromissos e obrigações e quaisquer outras finalidades, em qualquer tempo e sob qualquer condição. É proibida a reprodução ou utilização total ou parcial do presente sem a identificação da fonte.

3.3. Previsão de carga

A consolidação das previsões de carga para a 1ª Revisão Semanal do PMO de novembro apresenta novas projeções para o mês atual que indicam variações de 0,2% no Subsistema Sudeste/Centro-Oeste, -2,1% no Sul, 4,6% no Nordeste e 8,9% no Norte, em comparação com o mesmo mês do ano anterior.

A estimativa de fechamento da carga global na semana operativa atual (01/11 a 07/11) aponta, para o Sistema Interligado Nacional (SIN), uma variação de 1,5% em relação à previsão inicial para o período, com expectativa de 82.712 MW médios.

Para a próxima semana operativa (08/11 a 14/11), projeta-se um leve decréscimo de 0,7% na carga do SIN em relação à semana atual, totalizando 82.145 MW médios. Essa redução decorre, principalmente, do comportamento do Subsistema Sudeste/Centro-Oeste, cuja carga prevista é 0,7% inferior à da semana vigente, atingindo 45.228 MW médios.

As previsões de carga para a próxima semana consideram a sinalização meteorológica de avanço de uma frente fria sobre São Paulo, Rio de Janeiro, Espírito Santo e o litoral da Bahia já no início do período operativo, com atuação até 11/11. Esse intervalo deverá ser marcado por aumento de nebulosidade, ocorrência de precipitações e redução de temperatura.

No dia 12/11, uma nova frente fria deve avançar pelo Rio Grande do Sul, estendendo-se aos demais estados da Região Sul e ao litoral sul de São Paulo no dia seguinte (13/11), ocasionando maior nebulosidade e precipitação.

Mesmo com a passagem dessas frentes frias, espera-se estabilidade nas temperaturas extremas das regiões Sul, Sudeste e Centro-Oeste, comparadas às observadas na semana atual.

Por fim, para o mês de novembro, a carga foi atualizada em 1,4% acima da observada em outubro, considerando que o mês anterior apresentou temperaturas atípicas. As estimativas para os subsistemas Sudeste/Centro-Oeste e Norte permanecem próximas às de outubro, o que faz com que, mesmo com os incrementos de carga observados nas regiões Sul e Nordeste, a variação total do SIN entre os dois meses não seja tão expressiva.

Tabela 5 – Evolução da carga do PMO de Novembro de 2025

Subsistema	CARGA SEMANAL (MWmed)					CARGA MENSAL (MWmed)	
	1ª Sem	2ª Sem	3ª Sem	4ª Sem	5ª Sem	nov/25	Var. (%) nov/25 -> nov/24
SE/CO	45.536	45.228	45.273	44.714	45.472	45.207	0,2%
Sul	13.708	13.718	14.180	14.030	14.342	13.938	-2,1%
Nordeste	14.379	14.261	14.231	14.169	14.149	14.253	4,6%
Norte	9.089	8.938	8.943	8.901	8.853	8.960	8,9%
SIN	**82.712**	**82.145**	**82.627**	**81.814**	**82.816**	**82.358**	**1,4%**

O conteúdo desta publicação foi produzido pelo ONS com base em dados e informações de conhecimento público. É de responsabilidade exclusiva dos agentes e demais interessados a obtenção de outros dados e informações, a realização de análises, estudos e avaliações para fins de tomada de decisões, definição de estratégias de atuação, assunção de compromissos e obrigações e quaisquer outras finalidades, em qualquer tempo e sob qualquer condição. É proibida a reprodução ou utilização total ou parcial do presente sem a identificação da fonte.

3.4. Potência Hidráulica Total Disponível no SIN

O gráfico a seguir mostra a disponibilidade hidráulica total do SIN, para este mês, de acordo com o cronograma de manutenção informado pelos agentes para esta revisão.

Figura 16 – Potência hidráulica disponível no SIN

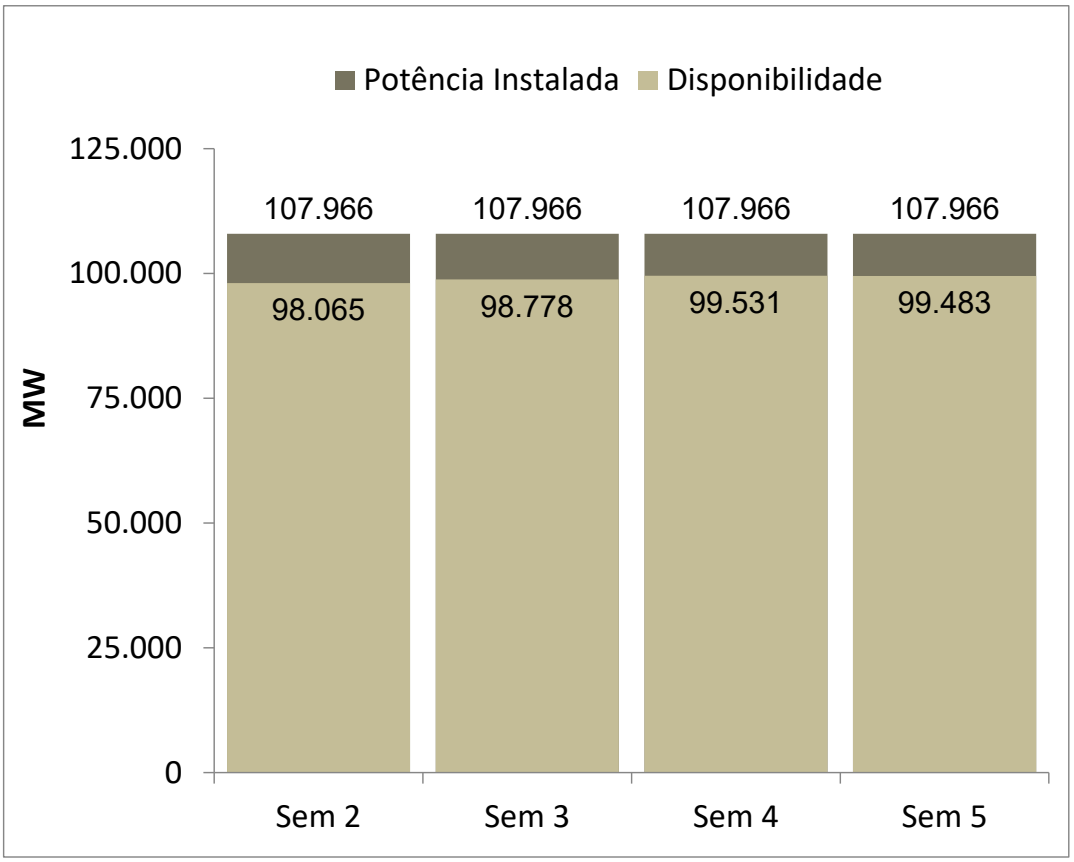

3.5. Armazenamentos Iniciais por Subsistema

Tabela 6 – Armazenamentos iniciais, por subsistema, considerados para esta semana operativa

Armazenamento (%EARmáx) - 0:00 h do dia 08/11/2025		
Subsistema	**Nível previsto na Revisão 0 do PMO Nov/2025**	**Partida informada pelos Agentes para a Revisão 1 do PMO Nov/2025**
SE/CO	43,8	44,0
S	89,5	92,3
NE	47,8	47,7
N	70,7	71,3

A primeira coluna da tabela acima corresponde ao armazenamento previsto na Revisão 0 do PMO de Novembro de 2025, para a 0:00 h do dia 08/11/2025. A segunda coluna apresenta os armazenamentos obtidos a partir dos níveis de partida informados pelos Agentes de Geração para seus aproveitamentos com reservatórios.

O conteúdo desta publicação foi produzido pelo ONS com base em dados e informações de conhecimento público. É de responsabilidade exclusiva dos agentes e demais interessados a obtenção de outros dados e informações, a realização de análises, estudos e avaliações para fins de tomada de decisões, definição de estratégias de atuação, assunção de compromissos e obrigações e quaisquer outras finalidades, em qualquer tempo e sob qualquer condição. É proibida a reprodução ou utilização total ou parcial do presente sem a identificação da fonte.

4. PRINCIPAIS RESULTADOS

4.1. Política de Operação Energética

Para esta semana operativa, está prevista a seguinte política de intercâmbio de energia entre regiões:

Região SE/CO:

- Manutenção da utilização dos recursos das bacias dos rios Grande, Paranaíba e Paraná, conforme necessidade de alocação para o atendimento à ponta de carga e controle de nível dos reservatórios;

Região Sul:

- Geração para controle do nível dos reservatórios em função das afluências, conforme possibilidade de alocação na carga do SIN;

Região NE:

- Operação minimizada, com redução de geração na cascata do Rio São Francisco, considerando o reservatório de Sobradinho na faixa de atenção;

Região Norte:

- Geração dimensionada para atendimento à ponta de carga.

4.2. Custo Marginal de Operação – CMO

A figura a seguir apresenta os Custos Marginais de Operação, em valores médios semanais, para as semanas operativas deste mês.

Figura 17 – CMO em valores médios

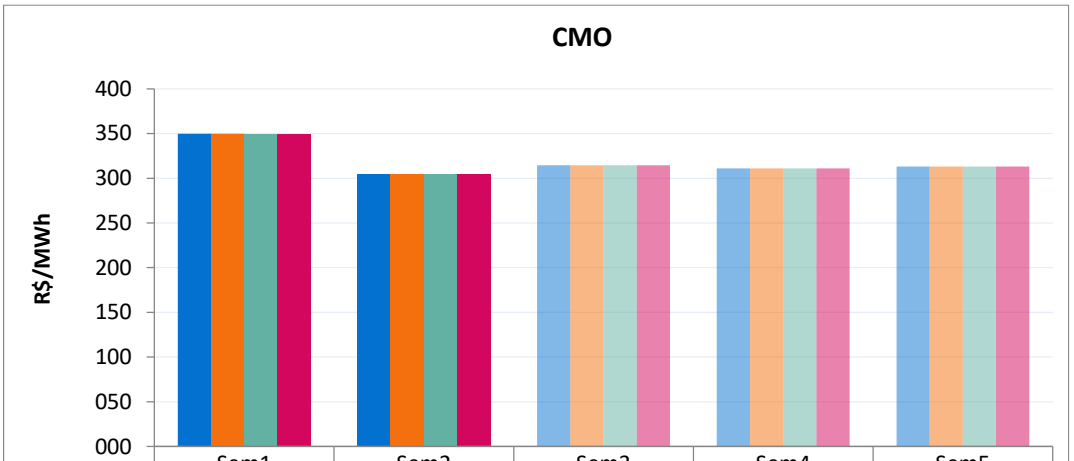

	Sem1	Sem2	Sem3	Sem4	Sem5
Sudeste	349,82	305,15	314,61	311,01	313,00
Sul	349,82	305,15	314,61	311,01	313,00
Nordeste	349,82	305,15	314,61	311,01	313,00
Norte	349,82	305,15	314,61	311,01	313,00

O conteúdo desta publicação foi produzido pelo ONS com base em dados e informações de conhecimento público. É de responsabilidade exclusiva dos agentes e demais interessados a obtenção de outros dados e informações, a realização de análises, estudos e avaliações para fins de tomada de decisões, definição de estratégias de atuação, assunção de compromissos e obrigações e quaisquer outras finalidades, em qualquer tempo e sob qualquer condição. É proibida a reprodução ou utilização total ou parcial do presente sem a identificação da fonte.

A tabela a seguir apresenta o custo marginal de operação, por subsistema e patamar de carga, para a próxima semana operativa.

Tabela 7 – CMO para esta semana operativa

Patamares de Carga	CMO (R$/MWh)			
	SE/CO	S	NE	N
Pesada	310,36	310,36	310,36	310,36
Média	306,61	306,61	306,61	306,61
Leve	300,89	300,89	300,89	300,89
Média Semanal	305,15	305,15	305,15	305,15

4.3. Energia Armazenada

O processo de otimização realizado pelo programa DECOMP indicou os armazenamentos mostrados na figura a seguir para as próximas semanas operativas do mês de novembro/2025.

Figura 18 – Energias Armazenadas nas semanas operativas do mês de novembro/2025.

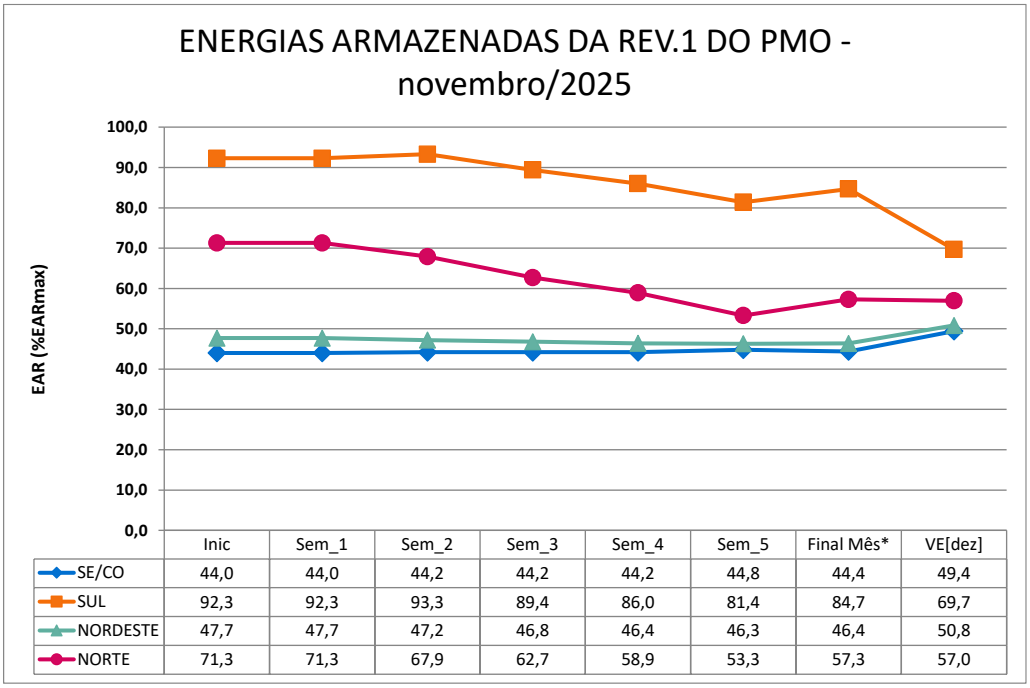

	Inic	Sem_1	Sem_2	Sem_3	Sem_4	Sem_5	Final Mês*	VE[dez]
SE/CO	44,0	44,0	44,2	44,2	44,2	44,8	44,4	49,4
SUL	92,3	92,3	93,3	89,4	86,0	81,4	84,7	69,7
NORDESTE	47,7	47,7	47,2	46,8	46,4	46,3	46,4	50,8
NORTE	71,3	71,3	67,9	62,7	58,9	53,3	57,3	57,0

Os armazenamentos da figura anterior estão expressos em percentual da Energia Armazenável Máxima de cada subsistema, que são mostradas na tabela a seguir.

Tabela 8 – Energia Armazenável Máxima por subsistema no PMO de novembro/2025.

ENERGIA ARMAZENÁVEL MÁXIMA (MWmed)		
Subsistema	novembro	dezembro
SE/CO	205.569	205.569
S	19.371	19.371
NE	51.718	51.718
N	15.842	15.864

O conteúdo desta publicação foi produzido pelo ONS com base em dados e informações de conhecimento público. É de responsabilidade exclusiva dos agentes e demais interessados a obtenção de outros dados e informações, a realização de análises, estudos e avaliações para fins de tomada de decisões, definição de estratégias de atuação, assunção de compromissos e obrigações e quaisquer outras finalidades, em qualquer tempo e sob qualquer condição. É proibida a reprodução ou utilização total ou parcial do presente sem a identificação da fonte.

5. GERAÇÃO TÉRMICA

A Figura 18 apresenta, para cada subsistema do SIN, o despacho térmico por modalidade indicado pelo DECOMP para esta semana operativa.

Figura 18 – Geração térmica para a próxima semana operativa

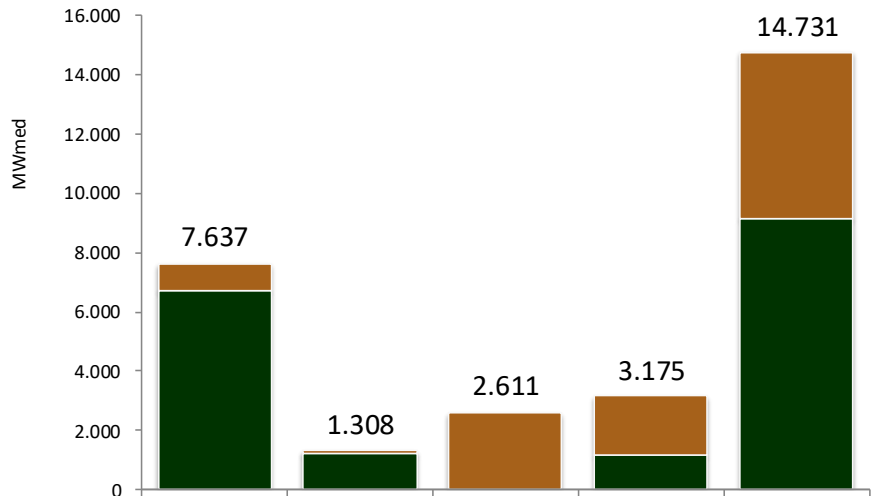

	SE/CO	SUL	NE	NORTE	SIN
TOTAL	7.637	1.308	2.611	3.175	14.731
ORDEM DE MÉRITO	925	63	2607	1983	5578
RESTRIÇÃO ELÉTRICA	0	0	0	0	0
INFLEXIBILIDADE	6712	1245	4	1192	9153

Na tabela abaixo segue a Indicação de despacho antecipado por ordem de mérito de custo para a semana de 10/01/2026 a 16/01/2026.

Tabela 8 – UTEs com contrato de combustível GNL

UTE			Benefício (R$/MWh)			Despacho antecipado por mérito		
Nome	Código	CVU (R$/MWh)	Carga Pesada	Carga Média	Carga Leve	Carga Pesada	Carga Média	Carga Leve
SANTA CRUZ	86	231,78	338,25	331,12	324,72	Sim	Sim	Sim
PSERGIPE I	224	305,45	327,98	323,63	320,79	Sim	Sim	Sim

(1) Comandado o despacho antecipado por ordem de mérito de custo nesse patamar
(2) NÃO foi comandado o despacho antecipado por ordem de mérito de custo nesse patamar

Assim sendo, há previsão de despacho antecipado por ordem de mérito de custo para as UTE Santa Cruz e Porto Sergipe I, para a semana de 10/01/2026 a 16/01/2026.

O conteúdo desta publicação foi produzido pelo ONS com base em dados e informações de conhecimento público. É de responsabilidade exclusiva dos agentes e demais interessados a obtenção de outros dados e informações, a realização de análises, estudos e avaliações para fins de tomada de decisões, definição de estratégias de atuação, assunção de compromissos e obrigações e quaisquer outras finalidades, em qualquer tempo e sob qualquer condição. É proibida a reprodução ou utilização total ou parcial do presente sem a identificação da fonte.

6. RESUMO DOS RESULTADOS DO PMO

As figuras a seguir apresentam um resumo dos resultados da revisão 1 de novembro/2025, com informações da Energia Natural Afluente (ENA), da Energia Armazenada (EAR) e do Custo Marginal de Operação (CMO) nos subsistemas do Sistema Interligado Nacional (SIN). São apresentados os valores semanais observados e previstos e o valor esperado dos cenários gerados para o mês de dezembro/2025.

Figura 19 – Resumo de novembro/2025 para o Subsistema Sudeste

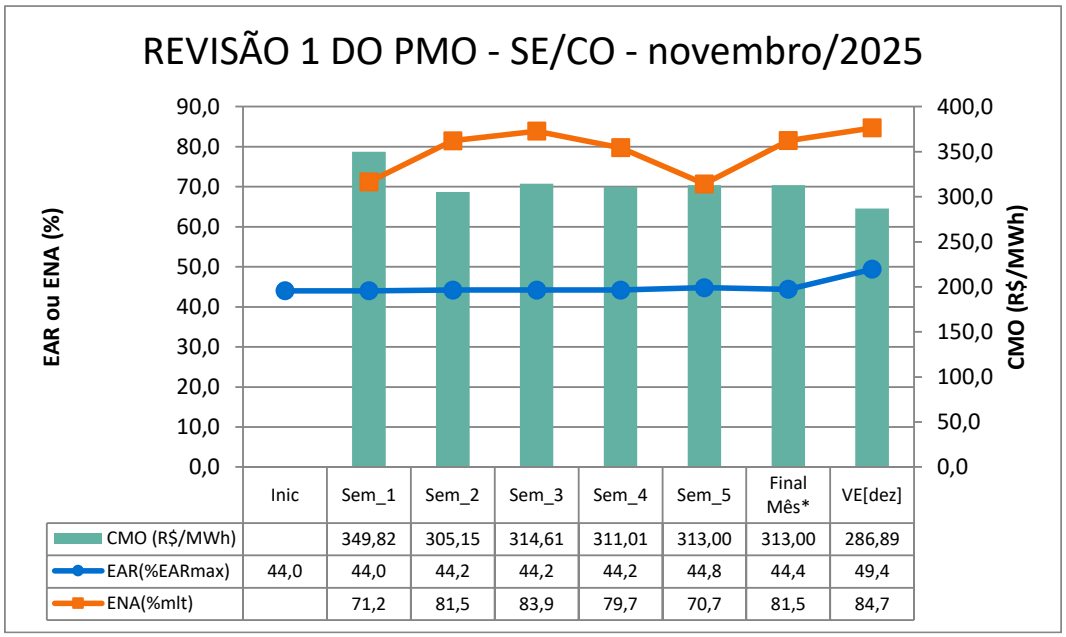

	Inic	Sem_1	Sem_2	Sem_3	Sem_4	Sem_5	Final Mês*	VE[dez]
CMO (R$/MWh)		349,82	305,15	314,61	311,01	313,00	313,00	286,89
EAR(%EARmax)	44,0	44,0	44,2	44,2	44,2	44,8	44,4	49,4
ENA(%mlt)		71,2	81,5	83,9	79,7	70,7	81,5	84,7

Figura 20 – Resumo de novembro/2025 para o Subsistema Sul

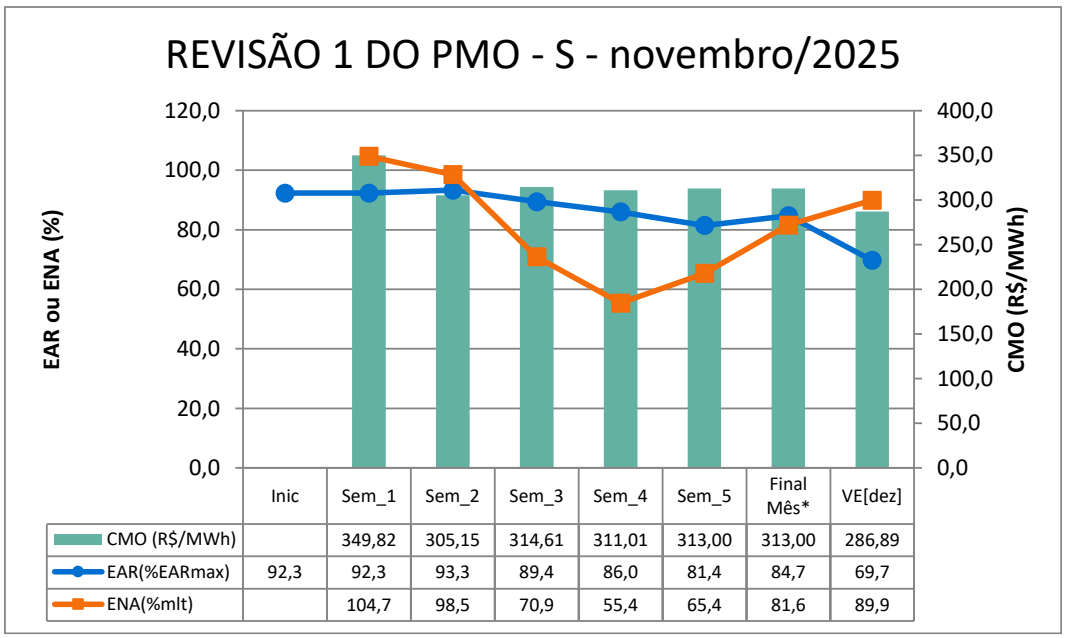

	Inic	Sem_1	Sem_2	Sem_3	Sem_4	Sem_5	Final Mês*	VE[dez]
CMO (R$/MWh)		349,82	305,15	314,61	311,01	313,00	313,00	286,89
EAR(%EARmax)	92,3	92,3	93,3	89,4	86,0	81,4	84,7	69,7
ENA(%mlt)		104,7	98,5	70,9	55,4	65,4	81,6	89,9

O conteúdo desta publicação foi produzido pelo ONS com base em dados e informações de conhecimento público. É de responsabilidade exclusiva dos agentes e demais interessados a obtenção de outros dados e informações, a realização de análises, estudos e avaliações para fins de tomada de decisões, definição de estratégias de atuação, assunção de compromissos e obrigações e quaisquer outras finalidades, em qualquer tempo e sob qualquer condição. É proibida a reprodução ou utilização total ou parcial do presente sem a identificação da fonte.

Figura 21 – Resumo de novembro/2025 para o Subsistema Nordeste

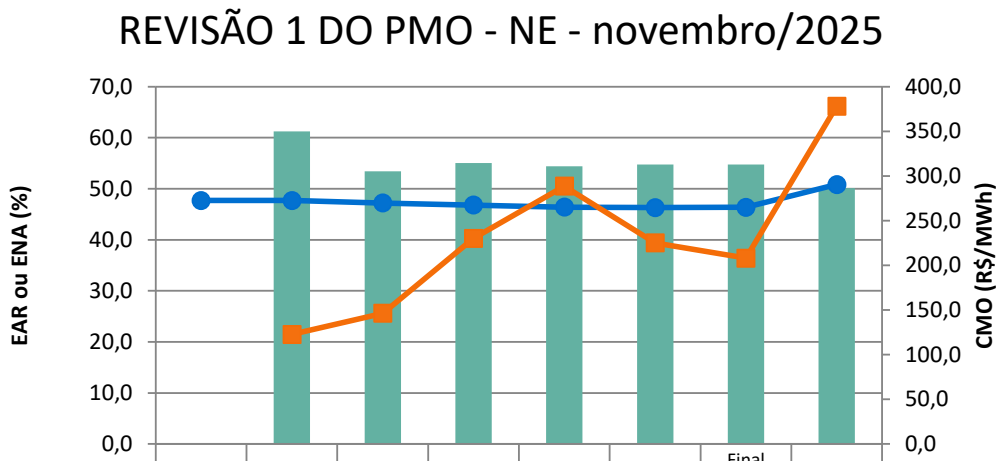

	Inic	Sem_1	Sem_2	Sem_3	Sem_4	Sem_5	Final Mês*	VE[dez]
CMO (R$/MWh)		349,82	305,15	314,61	311,01	313,00	313,00	286,46
EAR(%EARmax)	47,7	47,7	47,2	46,8	46,4	46,3	46,4	50,8
ENA(%mlt)		21,5	25,6	40,3	50,5	39,4	36,4	66,2

Figura 22 – Resumo de novembro/2025 para o Subsistema Norte

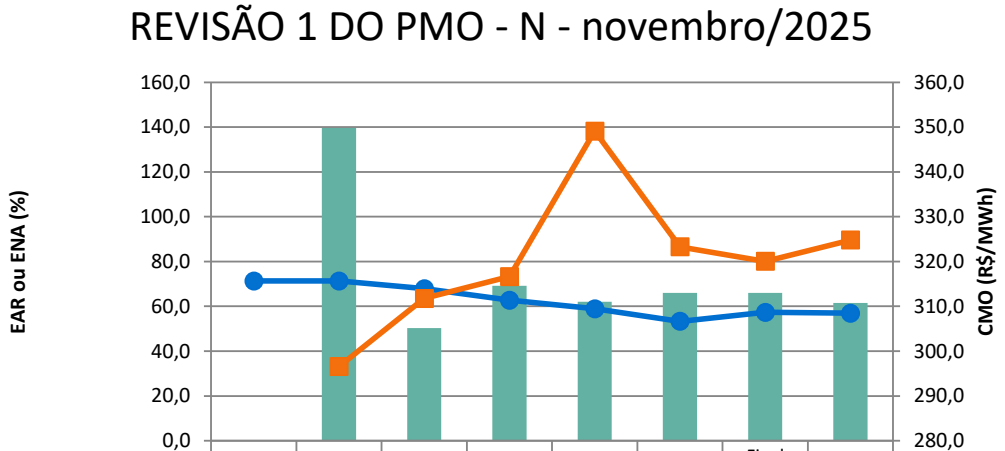

	Inic	Sem_1	Sem_2	Sem_3	Sem_4	Sem_5	Final Mês*	VE[dez]
CMO (R$/MWh)		349,82	305,15	314,61	311,01	313,00	313,00	310,78
EAR(%EARmax)	71,3	71,3	67,9	62,7	58,9	53,3	57,3	57,0
ENA(%mlt)		33,1	63,5	73,3	138,2	86,5	80,1	89,6

O conteúdo desta publicação foi produzido pelo ONS com base em dados e informações de conhecimento público. É de responsabilidade exclusiva dos agentes e demais interessados a obtenção de outros dados e informações, a realização de análises, estudos e avaliações para fins de tomada de decisões, definição de estratégias de atuação, assunção de compromissos e obrigações e quaisquer outras finalidades, em qualquer tempo e sob qualquer condição. É proibida a reprodução ou utilização total ou parcial do presente sem a identificação da fonte.

7. ARMAZENAMENTOS OPERATIVOS

Para uma melhor avaliação de diversos cenários hidrometeorológicos, notadamente, aqueles de curto prazo e suas influências nas previsões de vazões nos subsistemas, os resultados desta revisão do PMO contemplam cenários de afluências visando melhor representar a ocorrência de precipitação e, consequentemente, seus efeitos sobre as afluências e armazenamentos.

Apresentamos a seguir as correspondentes energias naturais afluentes e os resultados obtidos com a aplicação do cenário de afluência utilizado no estudo.

Tabela 9 – Previsão de ENA do caso de valor esperado das previsões de afluência

Subsistema	ENERGIAS NATURAIS AFLUENTES			
	Previsão Semanal		Previsão Mensal	
	(MWmed)	%MLT	(MWmed)	%MLT
SE/CO	26.218	83	25.644	82
Sul	9.755	100	7.926	82
Nordeste	1.343	26	1.909	36
Norte	2.510	62	3.232	80

Tabela 10 – Previsão de %EARmáx para o final do mês

Subsistema	% EARmáx 07/11	% EARmáx - 30/11
	NÍVEL INICIAL	NÍVEL PMO
SE/CO	44,0	44,4
Sul	92,3	84,7
Nordeste	47,7	46,4
Norte	71,3	57,3

O conteúdo desta publicação foi produzido pelo ONS com base em dados e informações de conhecimento público. É de responsabilidade exclusiva dos agentes e demais interessados a obtenção de outros dados e informações, a realização de análises, estudos e avaliações para fins de tomada de decisões, definição de estratégias de atuação, assunção de compromissos e obrigações e quaisquer outras finalidades, em qualquer tempo e sob qualquer condição. É proibida a reprodução ou utilização total ou parcial do presente sem a identificação da fonte.

8. RESERVATÓRIOS EQUIVALENTES DE ENERGIA

A seguir são apresentadas as previsões de Energia Natural Afluente para a próxima semana operativa e para o mês de novembro, bem como as previsões de Energia Armazenada nos Reservatórios Equivalentes de Energia – REE, desta revisão do PMO de Novembro de 2025.

Tabela 11 – Previsão de ENA por REE

Valor Esperado das Energias Naturais Afluentes				
REE	Previsão Semanal		Previsão Mensal	
	08/11/2025 a 14/11/2025		nov-25	
	(MWmed)	%MLT	(MWmed)	%MLT
Sudeste	2.811	55	3.388	66
Madeira	2.741	83	3.322	100
Teles Pires	944	65	1.197	82
Itaipu	5.649	182	4.792	154
Paraná	11.446	71	10.329	64
Paranapanema	2.045	85	2.091	87
Sul	4.629	95	3.546	73
Iguaçu	4.940	102	4.243	88
Nordeste	1.343	26	1.909	36
Norte	1.970	69	2.485	87
Belo Monte	426	43	666	68
Manaus	167	78	161	75

Tabela 12 – Previsão de %EARmáx por REE

% Energia Armazenável Máxima		
REE	Previsão Semanal	Previsão Mensal
	14-nov	30-nov
	(%EARmáx)	(%EARmáx)
Sudeste	53,0	53,7
Madeira	5,4	2,9
Teles Pires	23,4	23,0
Itaipu	100,0	100,0
Paraná	40,1	39,8
Paranapanema	53,7	57,8
Sul	91,0	84,0
Iguaçu	95,4	85,3
Nordeste	47,2	46,4
Norte	68,5	57,8
Belo Monte	40,0	55,8
Manaus	55,8	47,1

O conteúdo desta publicação foi produzido pelo ONS com base em dados e informações de conhecimento público. É de responsabilidade exclusiva dos agentes e demais interessados a obtenção de outros dados e informações, a realização de análises, estudos e avaliações para fins de tomada de decisões, definição de estratégias de atuação, assunção de compromissos e obrigações e quaisquer outras finalidades, em qualquer tempo e sob qualquer condição. É proibida a reprodução ou utilização total ou parcial do presente sem a identificação da fonte.

9. DESPACHO TÉRMICO POR MODALIDADE, PATAMAR DE CARGA E USINA

Nas tabelas abaixo, a diferenciação entre geração por inflexibilidade e por ordem de mérito tem caráter informativo, com o objetivo de detalhar a informação de inflexibilidade enviada pelos respectivos agentes para esta revisão do PMO. Ressalta-se que nas etapas de Programação Diária e Tempo Real, o montante despachado nas usinas termelétricas indicadas por ordem de mérito é plenamente intitulado como ordem de mérito.

REGIÃO SUDESTE/CENTRO-OESTE

Térmicas Potência (MW)	Combustível	CVU (R$/MWh)	Inflexibilidade			Ordem de Mérito			Total Mérito e INFL.			Razão Elétrica			Total UTE		
			P	M	L	P	M	L	P	M	L	P	M	L	P	M	L
ATLAN_CSA (255)	Resíduos	0,00	57,4	57,4	57,4				57,4	57,4	57,4				57,4	57,4	57,4
DAIA (44)	Diesel	---															
TNORTE 2 (349)	Óleo	---															
W.ARJONA O (177)	Diesel	---															
XAVANTES (54)	Diesel	---															
ANGRA 2 (1350)	Nuclear	20,12	1350,0	1350,0	1350,0	0,0	0,0	0,0	1350,0	1350,0	1350,0				1350,0	1350,0	1350,0
ANGRA 1 (640)	Nuclear	31,17	640,0	640,0	640,0	0,0	0,0	0,0	640,0	640,0	640,0				640,0	640,0	640,0
M.AZUL (566)	Gás	130,77	475,0	475,0	475,0	90,5	90,5	90,5	565,5	565,5	565,5				565,5	565,5	565,5
O.PINTADA (50)	Biomassa	152,20				50,0	50,0	50,0	50,0	50,0	50,0				50,0	50,0	50,0
UTE STA VI (41)	Biomassa	164,41				31,0	31,0	31,0	31,0	31,0	31,0				31,0	31,0	31,0
BAIXADA FL (530)	Gás	227,98				530,0	530,0	530,0	530,0	530,0	530,0				530,0	530,0	530,0
SANTA CRUZ (500)	GNL	231,78	420,0	500,0	500,0	80,0			500,0	500,0	500,0				500,0	500,0	500,0
ATLANTICO (235)	Resíduos	263,44	218,7	218,7	218,7	0,0	0,0	0,0	218,7	218,7	218,7				218,7	218,7	218,7
ST.CRUZ 34 (436)	Óleo	310,41															
LUIZORMELO (204)	GNL	349,89				204,0	204,0	204,0	204,0	204,0	204,0				204,0	204,0	204,0
CUBATAO (216)	Gás	374,61	210,0	210,0	210,0				210,0	210,0	210,0				210,0	210,0	210,0
UTE GNA I (1338)	Gás	441,58															
UTE GNA II (1673)	Gás	487,71	1672,0	1672,0	1672,0				1672,0	1672,0	1672,0				1672,0	1672,0	1672,0
KARKEY 013 (259)	Gás	766,90	31,0	31,0	31,0				31,0	31,0	31,0				31,0	31,0	31,0
KARKEY 019 (116)	Gás	766,90															
T.LAGOAS (350)	Gás	830,85	270,0	224,2	142,2				270,0	224,2	142,2				270,0	224,2	142,2
PORSUD I (116)	Gás	903,57															
PORSUD II (78)	Gás	904,64															
CUIABA CC (529)	Gás	905,60															
W.ARJONA (177)	Gás	918,28															
IBIRITE (235)	Gás	918,58															
TERMORIO (989)	Gás	920,43	570,0	465,3	406,5				570,0	465,3	406,5				570,0	465,3	406,5
T.MACAE (922)	Gás	959,03	594,0	649,8	630,0				594,0	649,8	630,0				594,0	649,8	630,0
NORTEFLU (826)	Gás	968,73															
VIANA (175)	Óleo	1058,52															
PAULINIA (16)	Gás	1089,93	15,7	15,7	15,7				15,7	15,7	15,7				15,7	15,7	15,7
LORM_PCS (36)	Gás	1102,55															
POVOACAO I (75)	Gás	1102,55															
VIANA I (37)	Gás	1102,55															
SEROPEDICA (360)	Gás	1143,47															
J.FORA (87)	Gás	1153,36	33,6	45,6	48,7				33,6	45,6	48,7				33,6	45,6	48,7
NPIRATINGA (572)	Gás	1387,40	209,0	228,6	221,7				209,0	228,6	221,7				209,0	228,6	221,7
PALMEIR_GO (176)	Diesel	1431,26															
TOTAL SE/CO (14789)			6766,4	6783,3	6618,9	1405,5	1405,5	1405,5	8171,9	8188,8	8024,4	0,0	0,0	0,0	8171,9	8188,8	8024,4

REGIÃO SUL

Térmicas Potência (MW)	Combustível	CVU (R$/MWh)	Inflexibilidade			Ordem de Mérito			Total Mérito e INFL.			Razão Elétrica			Total UTE		
			P	M	L	P	M	L	P	M	L	P	M	L	P	M	L
URUGUAIANA (640)	Gás	---															
PAMPA SUL (345)	Carvão	105,85	290,0	290,0	290,0	55,0	55,0	55,0	345,0	345,0	345,0				345,0	345,0	345,0
SAO SEPE (8)	Biomassa	118,74				8,0	8,0	8,0	8,0	8,0	8,0				8,0	8,0	8,0
FIGUEIRA (20)	Carvão	330,64															
J.LACER. C (330)	Carvão	341,04	300,0	300,0	300,0				300,0	300,0	300,0				300,0	300,0	300,0
J.LACER. B (220)	Carvão	397,24	220,0	220,0	220,0				220,0	220,0	220,0				220,0	220,0	220,0
J.LAC. A2 (110)	Carvão	406,63	110,0	110,0	110,0				110,0	110,0	110,0				110,0	110,0	110,0
J.LAC. A1 (80)	Carvão	475,13															
CANDIOTA_3 (350)	Carvão	522,02	325,0	325,0	325,0				325,0	325,0	325,0				325,0	325,0	325,0
B.BONITA I (10)	Gás	778,35															
ARAUCARIA (484)	Gás	780,00															
CANOAS (249)	Gás	1370,45															
TOTAL SUL (2846)			1245,0	1245,0	1245,0	63,0	63,0	63,0	1308,0	1308,0	1308,0	0,0	0,0	0,0	1308,0	1308,0	1308,0

O conteúdo desta publicação foi produzido pelo ONS com base em dados e informações de conhecimento público. É de responsabilidade exclusiva dos agentes e demais interessados a obtenção de outros dados e informações, a realização de análises, estudos e avaliações para fins de tomada de decisões, definição de estratégias de atuação, assunção de compromissos e obrigações e quaisquer outras finalidades, em qualquer tempo e sob qualquer condição. É proibida a reprodução ou utilização total ou parcial do presente sem a identificação da fonte.

REGIÃO NORDESTE

Térmicas Potência (MW)	Combustível	CVU (R$/MWh)	Inflexibilidade			Ordem de Mérito			Total Mérito e INFL.			Razão Elétrica			Total UTE		
			P	M	L	P	M	L	P	M	L	P	M	L	P	M	L
MARACANAU (168)	Óleo	---															
PETROLINA (136)	Óleo	---															
ERB CANDEI (17)	Biomassa	118,82	3,5	3,5	3,5	8,5	8,5	8,5	12,0	12,0	12,0				12,0	12,0	12,0
PROSP_I (28)	Gás	224,11				18,7	18,7	18,7	18,7	18,7	18,7				18,7	18,7	18,7
PROSP_III (56)	Gás	228,35				56,0	52,7	49,1	56,0	52,7	49,1				56,0	52,7	49,1
PROSP_II (37)	Gás	292,63				0,0	0,0	0,0									
P.PECEM1 (720)	Carvão	293,68				720,0	720,0	720,0	720,0	720,0	720,0				720,0	720,0	720,0
P.PECEM2 (365)	Carvão	305,16				365,0	365,0		365,0	365,0					365,0	365,0	0,0
PSERGIPE I (1593)	GNL	305,45				1593,0	1593,0	1593,0	1593,0	1593,0	1593,0				1593,0	1593,0	1593,0
VALE ACU (110)	Gás	450,86															
PERNAMBU_3 (201)	Óleo	806,31															
TERMOPE (550)	Gás	854,52															
SUAPE II (381)	Óleo	953,69															
T.BAHIA (186)	Gás	1028,24															
GLOBAL I (136)	Óleo	1191,71															
GLOBAL II (136)	Óleo	1191,71															
TERMOCABO (50)	Óleo	1393,68															
TERMONE (171)	Óleo	1753,30															
TERMOPB (171)	Óleo	1753,30															
POTIGUAR (53)	Diesel	1922,71															
POTIGUAR_3 (66)	Diesel	1922,71															
CAMPINA_GR (169)	Óleo	2056,84															
TERMOCEARA (223)	Óleo	2208,22															
C.MURICY 2 (144)	Óleo	2417,46															
PECEM 2 (144)	Óleo	2442,66															
TOTAL NE (5749)			3,5	3,5	3,5	2761,2	2757,9	2389,3	2764,7	2761,4	2392,8	0,0	0,0	0,0	2764,7	2761,4	2392,8

REGIÃO NORTE

Térmicas Potência (MW)	Combustível	CVU (R$/MWh)	Inflexibilidade			Ordem de Mérito			Total Mérito e INFL.			Razão Elétrica			Total UTE		
			P	M	L	P	M	L	P	M	L	P	M	L	P	M	L
APARECIDA (166)	Gás	115,69	75,0	75,0	75,0	49,0	56,6	64,8	124,0	131,6	139,8				124,0	131,6	139,8
JARAQUI (75)	Gás	115,69	29,0	29,0	29,0	34,0	34,0	34,0	63,0	63,0	63,0				63,0	63,0	63,0
PIRARUCU (73)	Gás	115,69	34,0	34,0	34,0	33,0	33,0	33,0	67,0	67,0	67,0				67,0	67,0	67,0
PORAQUE (85)	Gás	115,69	28,0	28,0	28,0	52,0	52,0	52,0	80,0	80,0	80,0				80,0	80,0	80,0
TAMBAQUI (93)	Gás	115,69	33,0	33,0	33,0	30,0	30,0	30,0	63,0	63,0	63,0				63,0	63,0	63,0
TUCUNARE (73)	Gás	115,69	34,0	34,0	34,0	31,0	31,0	31,0	65,0	65,0	65,0				65,0	65,0	65,0
UTE MAUA 3 (591)	Gás	115,69	264,0	264,0	264,0	326,8	326,8	326,8	590,8	590,8	590,8				590,8	590,8	590,8
MARANHAO3 (519)	Gás	115,99	490,0	490,0	490,0	10,8	14,6	22,1	500,8	504,6	512,1				500,8	504,6	512,1
MARANHAO V (338)	Gás	214,81				329,7	331,4	334,6	329,7	331,4	334,6				329,7	331,4	334,6
MARANHAOIV (338)	Gás	214,81				329,7	331,4	334,6	329,7	331,4	334,6				329,7	331,4	334,6
PARNAIBA_V (386)	Vapor	228,35				239,0	239,0	239,0	239,0	239,0	239,0				239,0	239,0	239,0
JAGUATI II (141)	Gas	276,32				126,2	121,4	112,3	126,2	121,4	112,3				126,2	121,4	112,3
P. ITAQUI (360)	Carvão	297,12				360,1	360,1	360,1	360,1	360,1	360,1				360,1	360,1	360,1
N.VENECIA2 (270)	Gás	308,07	180,0	180,0	180,0	80,3			260,3	180,0	180,0				260,3	180,0	180,0
BONFIM (12)	Biomassa	555,69	5,0	5,0	5,0				5,0	5,0	5,0				5,0	5,0	5,0
CANTA (12)	Biomassa	555,69	5,0	5,0	5,0				5,0	5,0	5,0				5,0	5,0	5,0
PAU RAINHA (12)	Biomassa	555,69	5,0	5,0	5,0				5,0	5,0	5,0				5,0	5,0	5,0
SANTA LUZ (12)	Biomassa	555,69	5,0	5,0	5,0				5,0	5,0	5,0				5,0	5,0	5,0
PARNAIB_IV (56)	Gás	825,85															
BBF BALIZA (18)	Biomassa	876,44	5,0	5,0	5,0				5,0	5,0	5,0				5,0	5,0	5,0
GERAMAR1 (166)	Óleo	973,33															
GERAMAR2 (166)	Óleo	973,33															
PALMAPLAN (12)	Biomassa	1302,32															
M.C.SUCUBA (42)	Diesel	2060,72															
TOTAL NORTE (4303)			1192,0	1192,0	1192,0	2031,6	1961,3	1974,3	3223,6	3153,3	3166,3	0,0	0,0	0,0	3223,6	3153,3	3166,3

O conteúdo desta publicação foi produzido pelo ONS com base em dados e informações de conhecimento público. É de responsabilidade exclusiva dos agentes e demais interessados a obtenção de outros dados e informações, a realização de análises, estudos e avaliações para fins de tomada de decisões, definição de estratégias de atuação, assunção de compromissos e obrigações e quaisquer outras finalidades, em qualquer tempo e sob qualquer condição. É proibida a reprodução ou utilização total ou parcial do presente sem a identificação da fonte.