1. APRESENTAÇÃO

Na semana de 03/01 a 09/01/2026, houve precipitação nas bacias dos rios Madeira, Tapajós, Xingu, Tocantins, São Francisco e Paranaíba.

Na semana de 10/01 a 16/01/2026, deve ocorrer precipitação as bacias dos rios Uruguai, Jacuí, Iguaçu e Madeira.

Os valores médios semanais do Custo Marginal de Operação – CMO dos subsistemas do SIN sofreram as seguintes alterações em relação à semana anterior:

- SE/CO: de R$ 119,10/MWh para R$ 296,18/MWh
- Sul: de R$ 119,10/MWh para R$ 296,18/MWh
- Nordeste: de R$ 119,10/MWh para R$ 295,73/MWh
- Norte: de R$ 289,25/MWh para R$ 296,18/MWh

Desde o dia 01/01/2020, o despacho por ordem de mérito é indicado diariamente pelos resultados do modelo DESSEM. Assim, o despacho por ordem de mérito semanal, conforme publicado nesse documento, tem caráter apenas informativo. Da mesma forma, desde o dia 01/01/2021, a formação de preço deixou o formato semanal/patamar de carga e passou a ser horário, de acordo também com os resultados do modelo DESSEM.

2. NOTÍCIAS

Nos dias 29 e 30 de janeiro será realizada a reunião de elaboração do PMO de Fevereiro de 2026, com transmissão ao vivo através do site do ONS.

3. INFORMAÇÕES CONJUNTURAIS PARA ELABORAÇÃO DO PMO

3.1. Informações hidrometeorológicas

3.1.1. Condições antecedentes

A configuração de uma Zona de Convergência do Atlântico Sul (ZCAS) entre as Regiões Norte, Centro-Oeste e Sudeste, organizou uma faixa de precipitação nas bacias das regiões. Os maiores acumulados ocorreram nas bacias dos rios Madeira, Tapajós, Xingu, Tocantins, São Francisco e Paranaíba, com valores entre o normal e acima da média. As demais bacias do SIN registraram precipitação abaixo da média (Figura 1).

O conteúdo desta publicação foi produzido pelo ONS com base em dados e informações de conhecimento público. É de responsabilidade exclusiva dos agentes e demais interessados a obtenção de outros dados e informações, a realização de análises, estudos e avaliações para fins de tomada de decisões, definição de estratégias de atuação, assunção de compromissos e obrigações e quaisquer outras finalidades, em qualquer tempo e sob qualquer condição. É proibida a reprodução ou utilização total ou parcial do presente sem a identificação da fonte.

Figura 1 – Precipitação observada (mm) no período de 03 a 08/01/2026

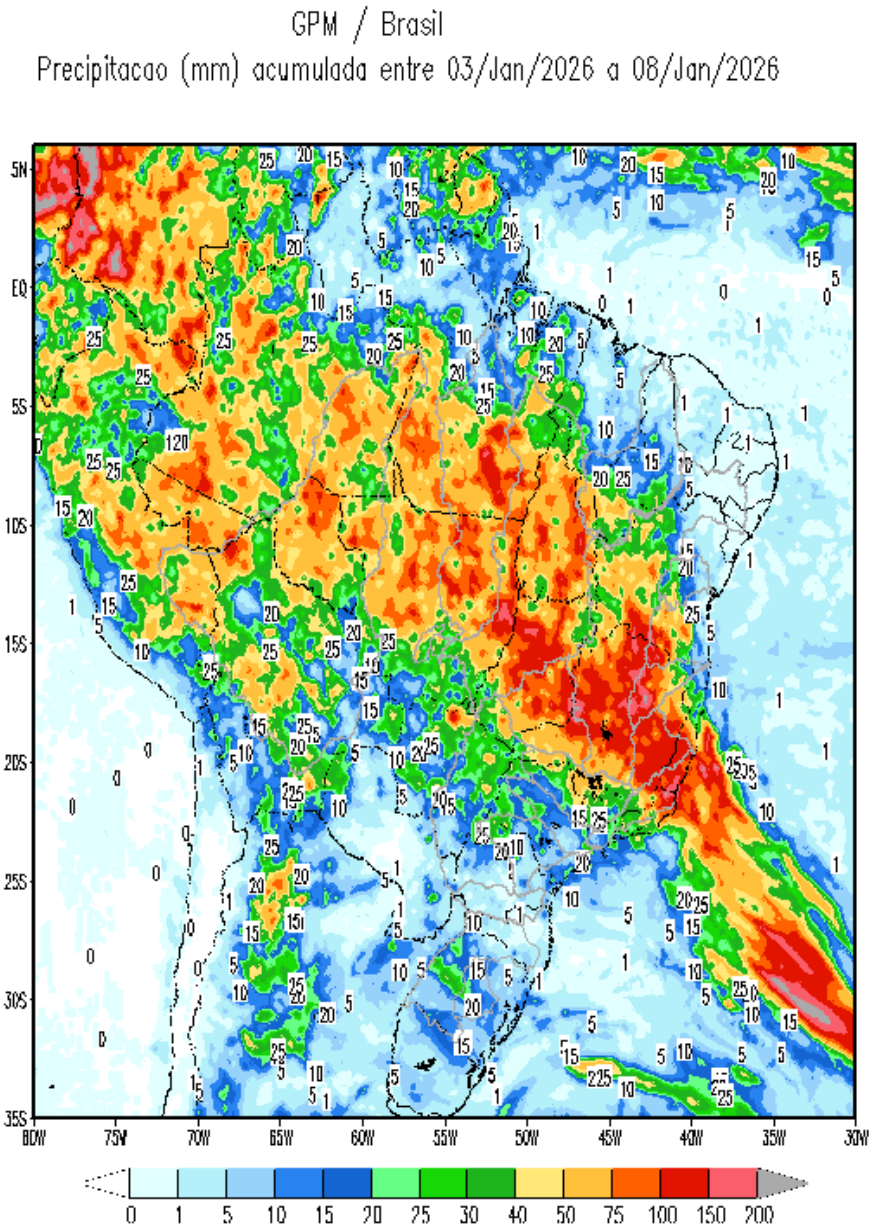

A Tabela 1 apresenta as energias naturais afluentes das semanas recentes. São apresentados os valores verificados na semana 27/12/2025 a 02/01/2026 e os estimados para fechamento da semana de 03/01/2026 a 09/01/2026.

Tabela 1 – Tendência hidrológica da ENA da Revisão 2 de Janeiro/2026

Revisão 2 do PMO de Janeiro/2026 - ENAs				
Subsistema	27/12 a 02/01/2026		03/01 a 09/01/2026	
	MWmed	%MLT	MWmed	%MLT
SE/CO	34.154	64	38.753	59
S	9.931	131	8.243	109
NE	5.772	54	6.308	47
N	8.345	80	7.910	50

O conteúdo desta publicação foi produzido pelo ONS com base em dados e informações de conhecimento público. É de responsabilidade exclusiva dos agentes e demais interessados a obtenção de outros dados e informações, a realização de análises, estudos e avaliações para fins de tomada de decisões, definição de estratégias de atuação, assunção de compromissos e obrigações e quaisquer outras finalidades, em qualquer tempo e sob qualquer condição. É proibida a reprodução ou utilização total ou parcial do presente sem a identificação da fonte.

3.1.2. Previsão para a próxima semana

A próxima semana operativa se inicia com a atuação de uma frente fria no Rio Grande do Sul e no litoral de Santa Catarina, ocasionando precipitação nas bacias das regiões. No decorrer da semana, áreas de instabilidade ocasionam precipitação isolada nas bacias dos rios Iguaçu, Paranapanema, Paraná, Tietê e Grande. Uma nova frente fria avança pelo litoral da Região Sul no final da semana operativa, sexta-feira, ocasionando chuva nas bacias das regiões. Os maiores totais previstos são para as bacias dos rios Uruguai, Jacuí, Iguaçu e Madeira (Figura 2).

Figura 2 - Precipitação acumulada prevista pelo modelo ECMWF - período de 10 a 16/01/2026

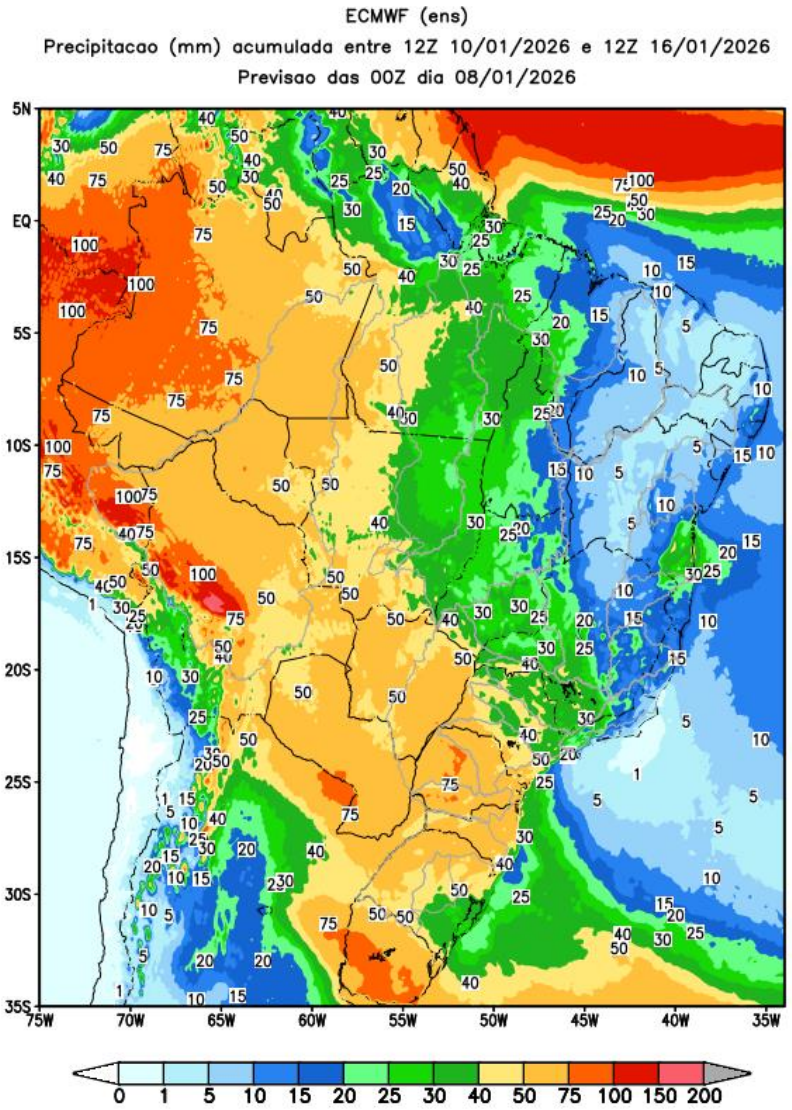

O conteúdo desta publicação foi produzido pelo ONS com base em dados e informações de conhecimento público. É de responsabilidade exclusiva dos agentes e demais interessados a obtenção de outros dados e informações, a realização de análises, estudos e avaliações para fins de tomada de decisões, definição de estratégias de atuação, assunção de compromissos e obrigações e quaisquer outras finalidades, em qualquer tempo e sob qualquer condição. É proibida a reprodução ou utilização total ou parcial do presente sem a identificação da fonte.

Em comparação com os valores estimados para a semana em curso, prevê-se para a próxima semana operativa ascensão nas afluências do subsistema Norte e recessão nas afluências dos subsistemas Sudeste/Centro-Oeste, Sul e Nordeste. A previsão mensal para janeiro indica a ocorrência de afluências abaixo da média histórica para os subsistemas Sudeste/Centro-Oeste, Nordeste e Norte e acima da média histórica para o subsistema Sul.

Tabela 2 – Previsão de ENAs da Revisão 2 de Janeiro/2026

Revisão 2 do PMO de Janeiro/2026 - ENAs previstas				
Subsistema	10/01 a 16/01/2026		Mês de janeiro	
	MWmed	%MLT	MWmed	%MLT
SE/CO	35.944	55	42.820	65
S	7.231	96	7.731	102
NE	4.881	36	5.452	41
N	8.324	53	9.333	59

O conteúdo desta publicação foi produzido pelo ONS com base em dados e informações de conhecimento público. É de responsabilidade exclusiva dos agentes e demais interessados a obtenção de outros dados e informações, a realização de análises, estudos e avaliações para fins de tomada de decisões, definição de estratégias de atuação, assunção de compromissos e obrigações e quaisquer outras finalidades, em qualquer tempo e sob qualquer condição. É proibida a reprodução ou utilização total ou parcial do presente sem a identificação da fonte.

As figuras a seguir ilustram as ENAs semanais verificadas e previstas para as Revisões 1 e 2 do PMO de Janeiro/2026.

Figura 3 - Energias Naturais Afluentes ao Subsistema Sudeste/Centro-Oeste das revisões 1 e 2 do PMO de janeiro/2026

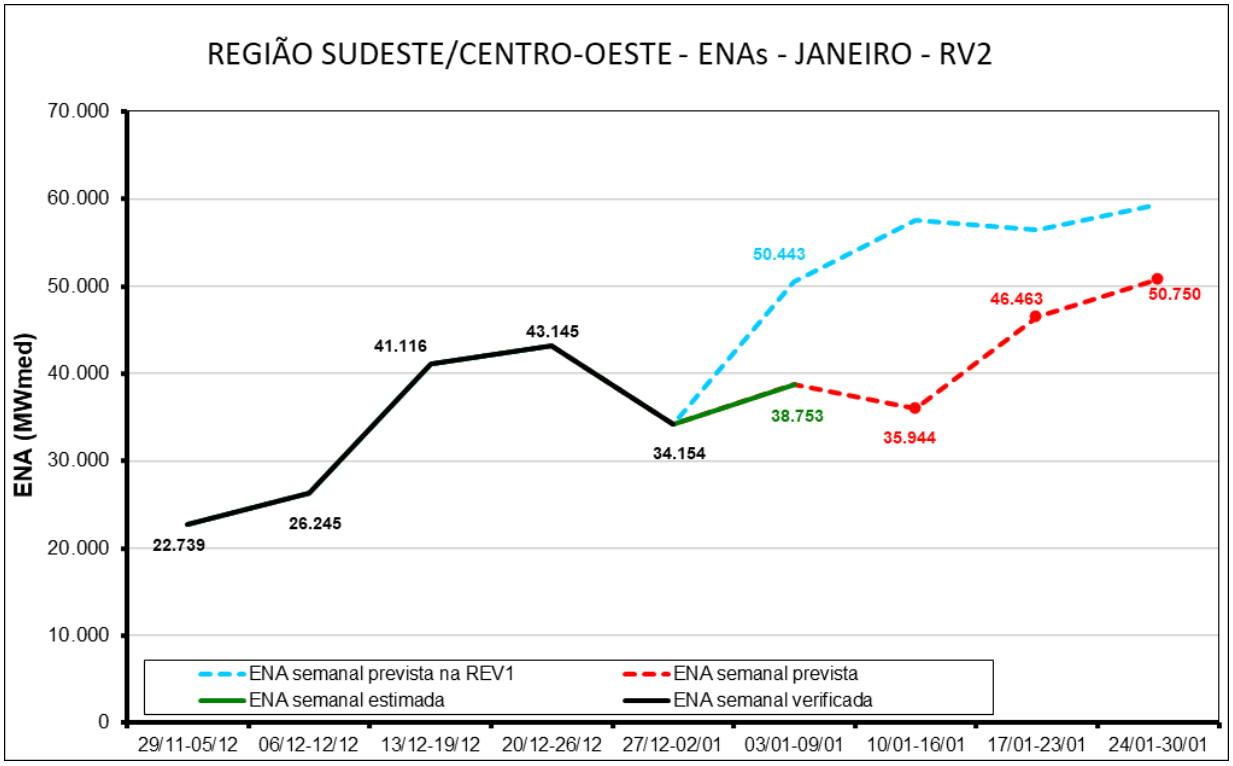

Figura 4 - Energias Naturais Afluentes ao Subsistema Sul das revisões 1 e 2 do PMO de janeiro/2026

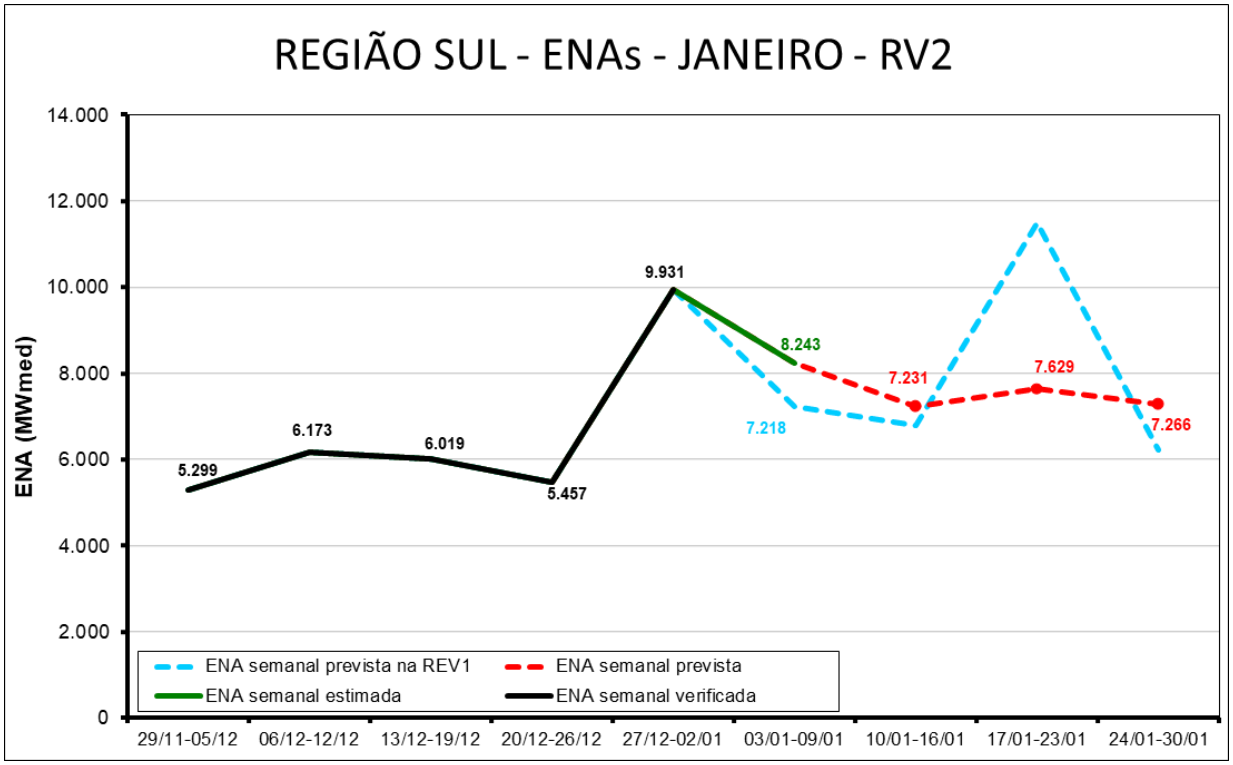

O conteúdo desta publicação foi produzido pelo ONS com base em dados e informações de conhecimento público. É de responsabilidade exclusiva dos agentes e demais interessados a obtenção de outros dados e informações, a realização de análises, estudos e avaliações para fins de tomada de decisões, definição de estratégias de atuação, assunção de compromissos e obrigações e quaisquer outras finalidades, em qualquer tempo e sob qualquer condição. É proibida a reprodução ou utilização total ou parcial do presente sem a identificação da fonte.

Figura 5 - Energias Naturais Afluentes ao Subsistema Nordeste das revisões 1 e 2 do PMO de janeiro/2026

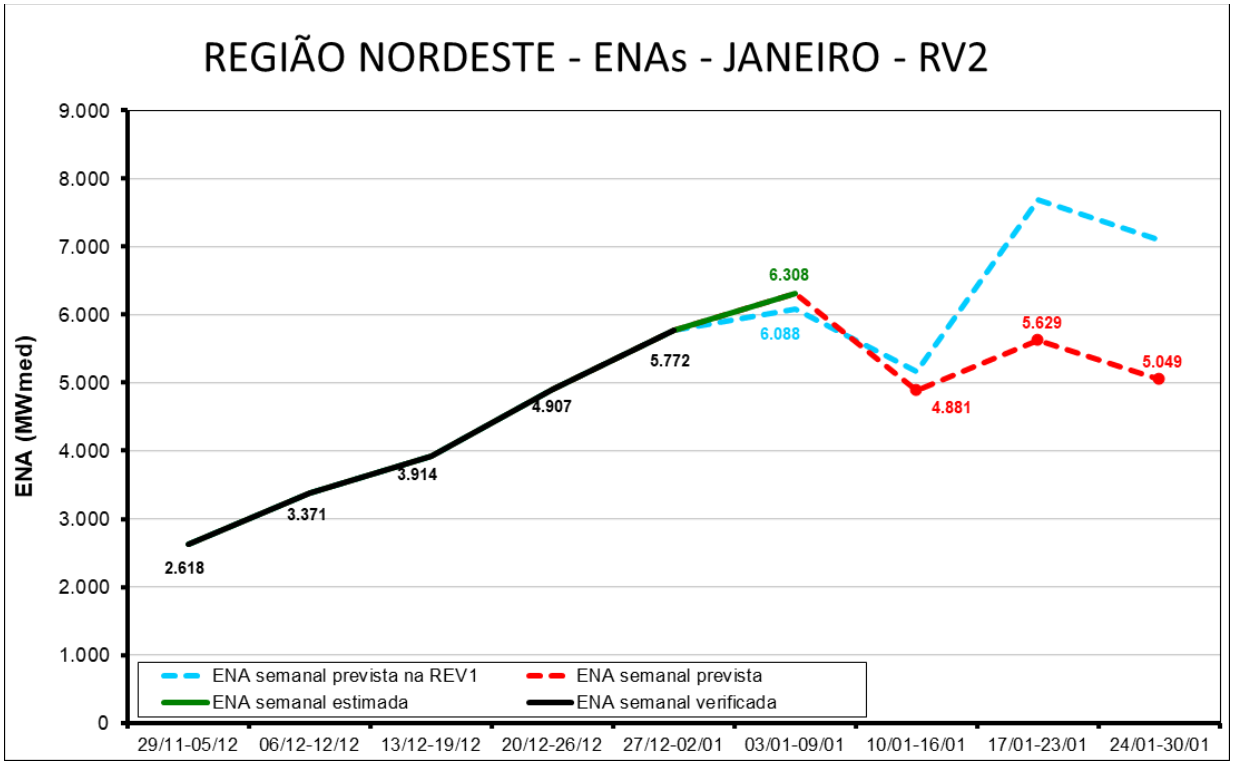

Figura 6 - Energias Naturais Afluentes ao Subsistema Norte das revisões 1 e 2 do PMO de janeiro/2026

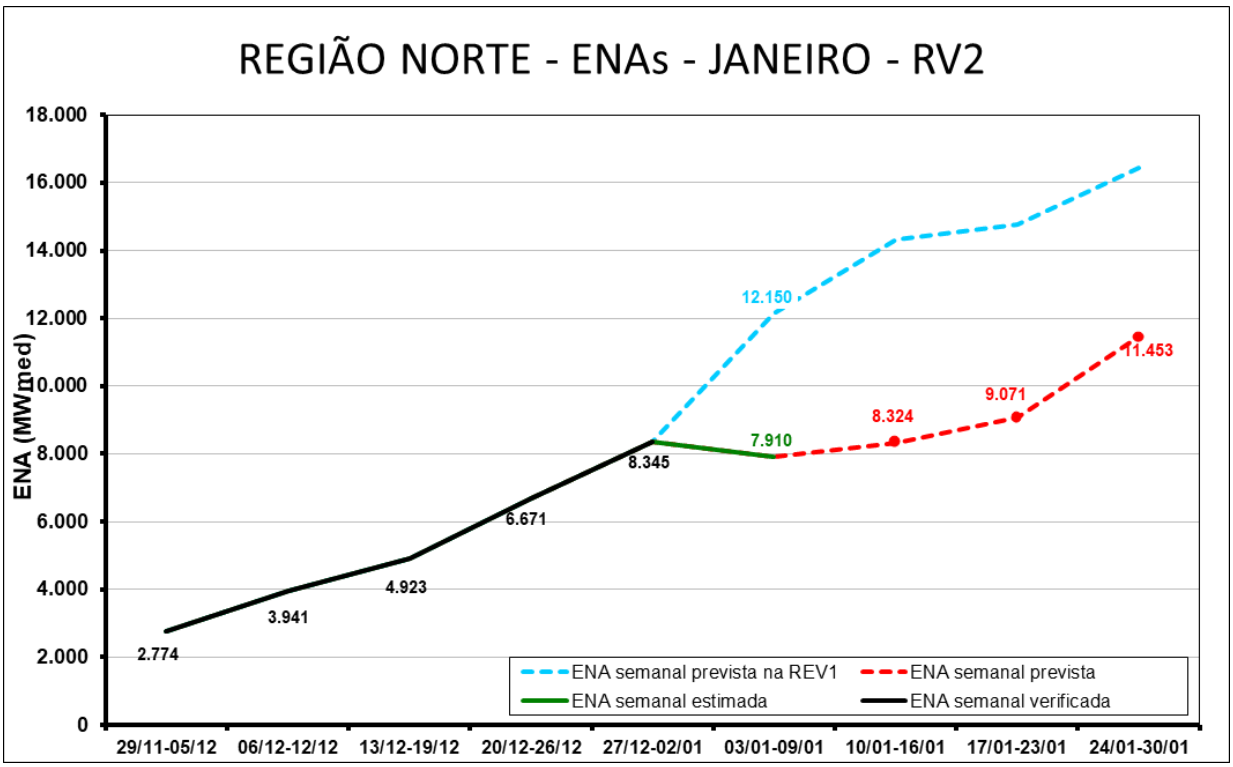

O conteúdo desta publicação foi produzido pelo ONS com base em dados e informações de conhecimento público. É de responsabilidade exclusiva dos agentes e demais interessados a obtenção de outros dados e informações, a realização de análises, estudos e avaliações para fins de tomada de decisões, definição de estratégias de atuação, assunção de compromissos e obrigações e quaisquer outras finalidades, em qualquer tempo e sob qualquer condição. É proibida a reprodução ou utilização total ou parcial do presente sem a identificação da fonte.

3.1.3. Cenários de ENAs para a Revisão 2 de Janeiro/2026

As figuras a seguir apresentam as características dos cenários de energias naturais afluentes gerados na revisão 2 de janeiro/2026, para acoplamento com a FCF do mês de fevereiro/2026. São mostradas, para os quatro subsistemas, as amplitudes e as Funções de Distribuição Acumulada dos cenários de ENA, comparativamente com os valores considerados para as revisões anteriores do PMO de janeiro/2026.

Figura 7 - Amplitude dos Cenários de ENA para o Subsistema Sudeste, em %MLT, para a Revisão 2 de Janeiro/2026

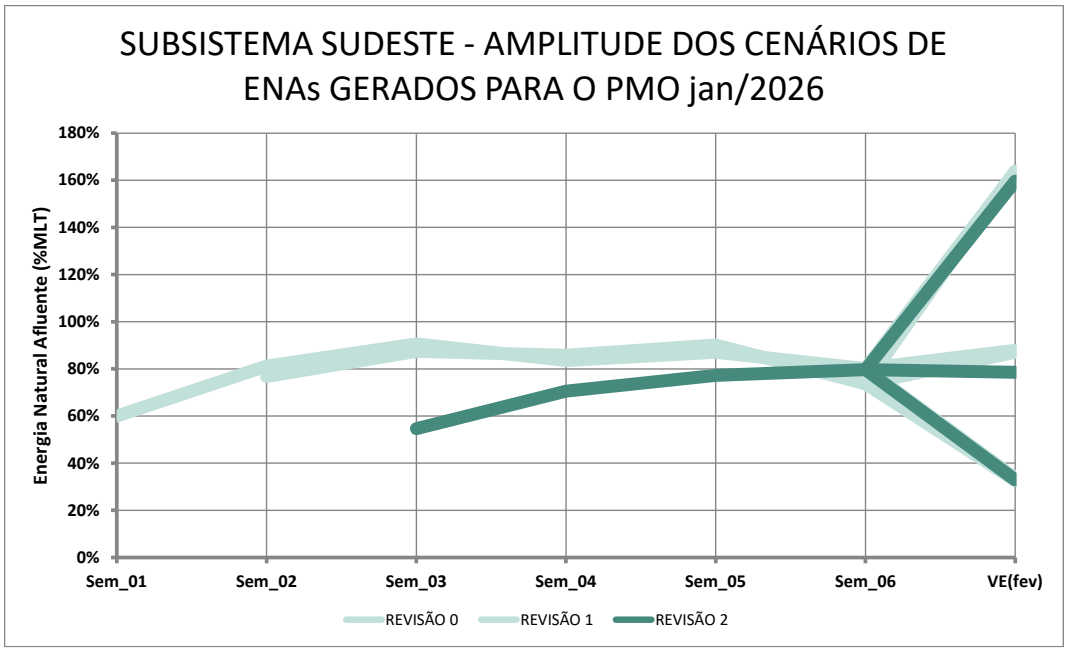

Figura 8 - Função de Distribuição Acumulada dos Cenários para o Subsistema Sudeste para a Revisão 2 de Janeiro/2026

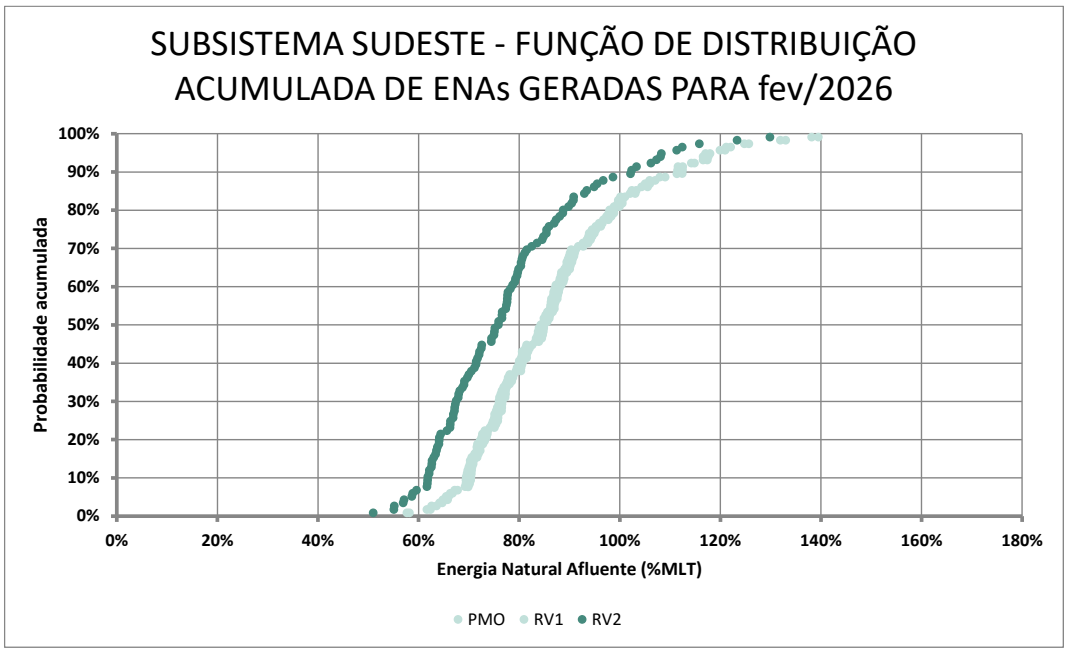

O conteúdo desta publicação foi produzido pelo ONS com base em dados e informações de conhecimento público. É de responsabilidade exclusiva dos agentes e demais interessados a obtenção de outros dados e informações, a realização de análises, estudos e avaliações para fins de tomada de decisões, definição de estratégias de atuação, assunção de compromissos e obrigações e quaisquer outras finalidades, em qualquer tempo e sob qualquer condição. É proibida a reprodução ou utilização total ou parcial do presente sem a identificação da fonte.

Figura 9 - Amplitude dos Cenários de ENA para o Subsistema Sul, em %MLT, para a Revisão 2 de Janeiro/2026

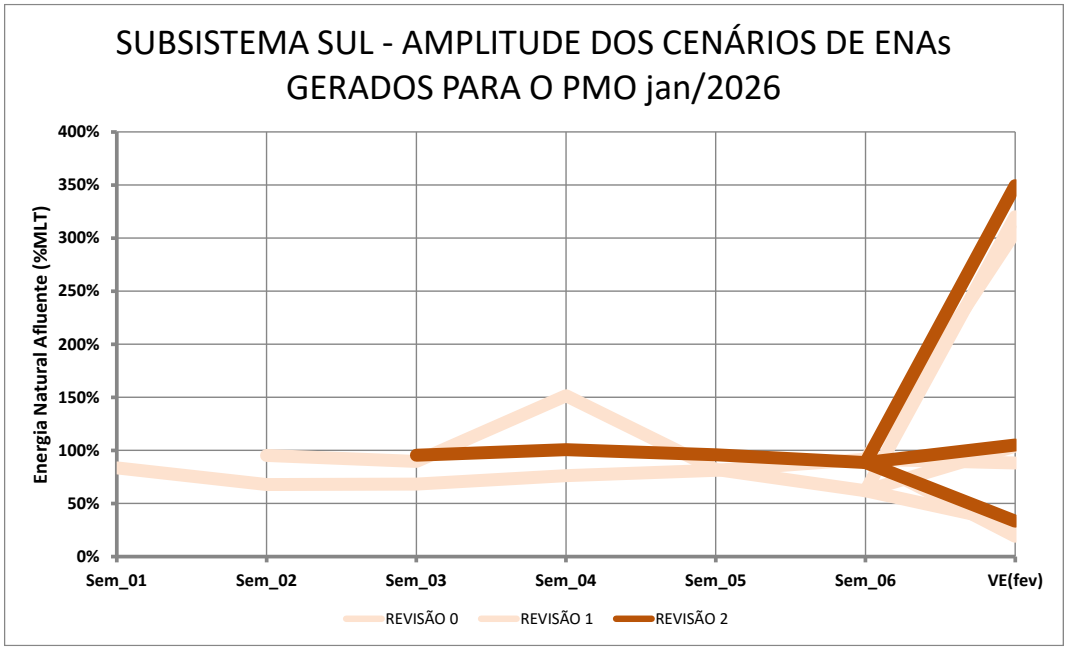

Figura 10 - Função de Distribuição Acumulada dos Cenários para o Subsistema Sul para a Revisão 2 de Janeiro/2026

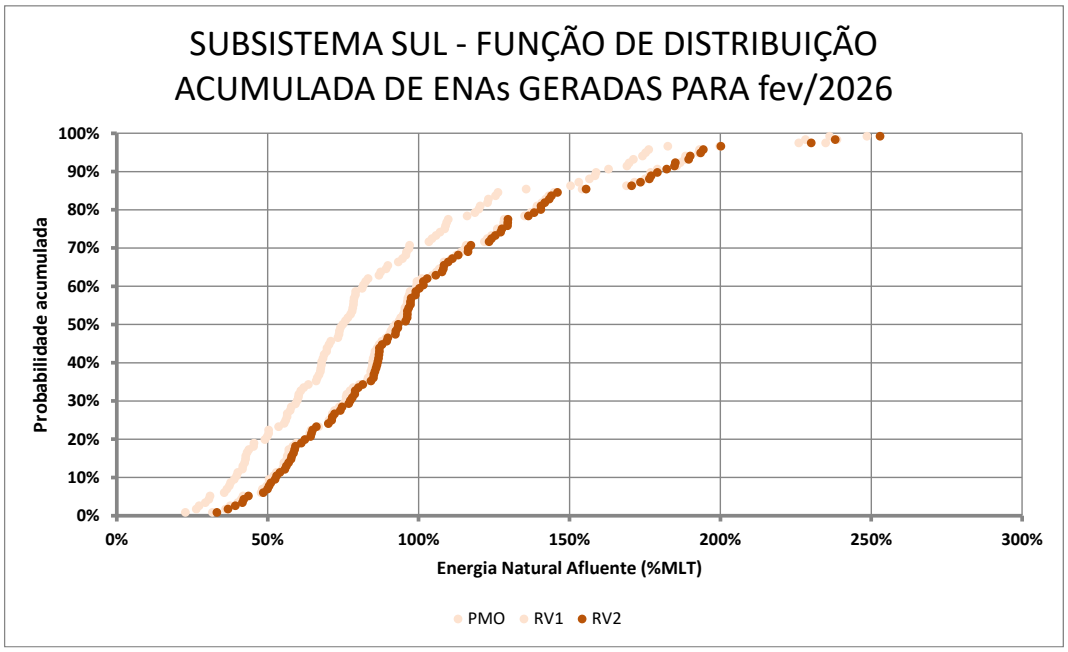

O conteúdo desta publicação foi produzido pelo ONS com base em dados e informações de conhecimento público. É de responsabilidade exclusiva dos agentes e demais interessados a obtenção de outros dados e informações, a realização de análises, estudos e avaliações para fins de tomada de decisões, definição de estratégias de atuação, assunção de compromissos e obrigações e quaisquer outras finalidades, em qualquer tempo e sob qualquer condição. É proibida a reprodução ou utilização total ou parcial do presente sem a identificação da fonte.

Figura 11 - Amplitude dos Cenários de ENA para o Subsistema Nordeste em %MLT, para a Revisão 2 de Janeiro/2026

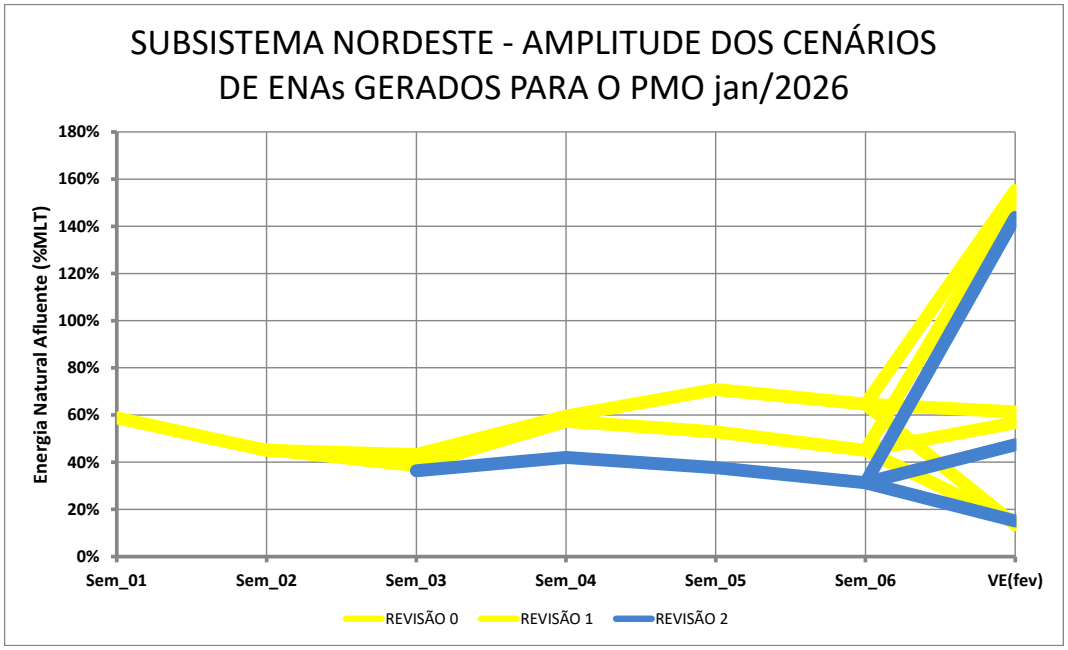

Figura 12 - Função de Distribuição Acumulada dos Cenários para o Subsistema Nordeste para a Revisão 2 de Janeiro/2026

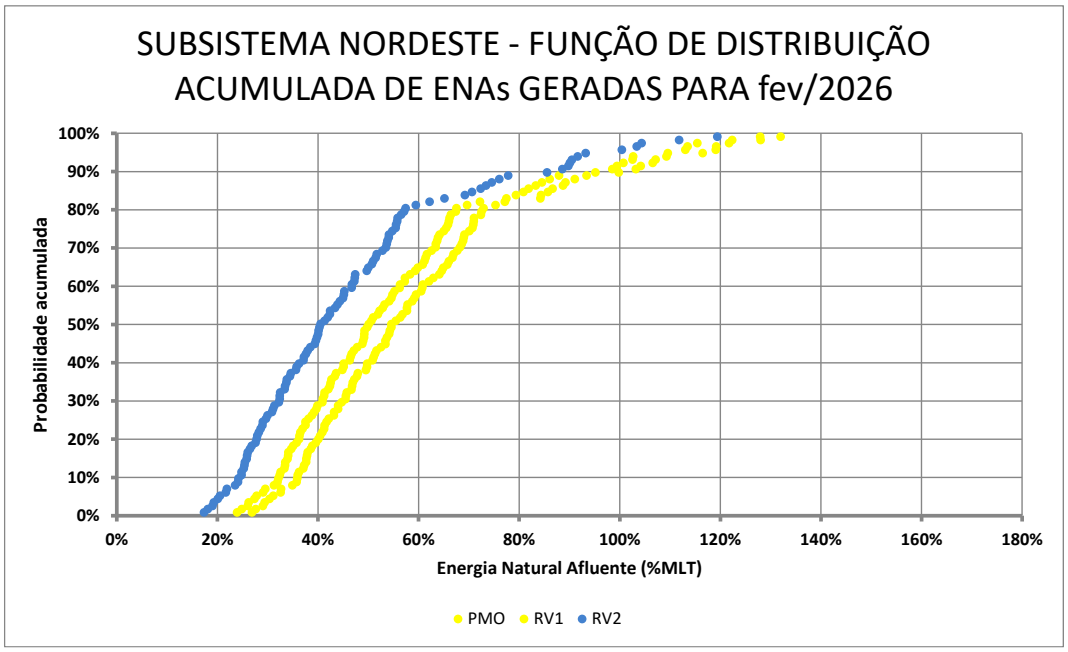

O conteúdo desta publicação foi produzido pelo ONS com base em dados e informações de conhecimento público. É de responsabilidade exclusiva dos agentes e demais interessados a obtenção de outros dados e informações, a realização de análises, estudos e avaliações para fins de tomada de decisões, definição de estratégias de atuação, assunção de compromissos e obrigações e quaisquer outras finalidades, em qualquer tempo e sob qualquer condição. É proibida a reprodução ou utilização total ou parcial do presente sem a identificação da fonte.

Figura 13 - Amplitude dos Cenários de ENA para o Subsistema Norte, em %MLT, para a revisão 2 de janeiro/2026

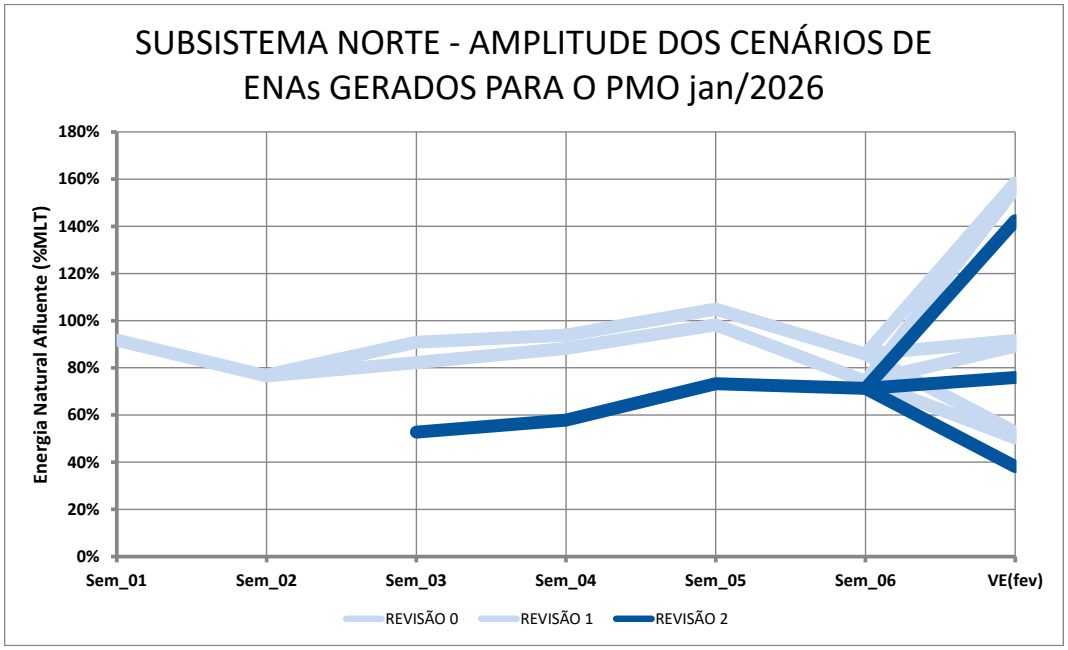

Figura 14 - Função de Distribuição Acumulada dos Cenários para o Subsistema Norte para a Revisão 2 de Janeiro/2026

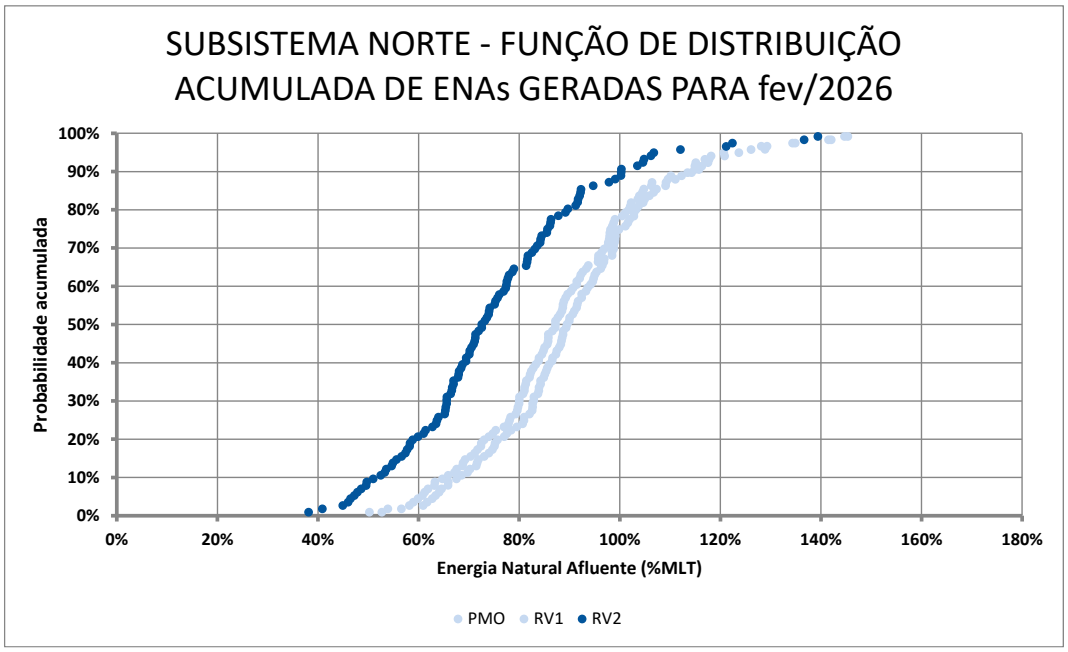

O conteúdo desta publicação foi produzido pelo ONS com base em dados e informações de conhecimento público. É de responsabilidade exclusiva dos agentes e demais interessados a obtenção de outros dados e informações, a realização de análises, estudos e avaliações para fins de tomada de decisões, definição de estratégias de atuação, assunção de compromissos e obrigações e quaisquer outras finalidades, em qualquer tempo e sob qualquer condição. É proibida a reprodução ou utilização total ou parcial do presente sem a identificação da fonte.

Os valores da MLT (Média de Longo Termo) das energias naturais afluentes para os meses de janeiro/2026 e fevereiro/2026 são apresentados na tabela a seguir.

Tabela 3 – MLT da ENA nos meses de janeiro/2026 e fevereiro/2026

MLT das ENAs (MWmed)		
Subsistema	janeiro	fevereiro
SE/CO	65.813	70.844
S	7.573	8.249
NE	13.415	14.185
N	15.785	22.743

3.2. Limites de Intercâmbio entre Subsistemas

Os limites elétricos de intercâmbio de energia entre subsistemas são de fundamental importância para o processo de otimização energética, sendo determinantes para a definição das políticas de operação e do CMO para cada subsistema. Estes limites são influenciados por intervenções na malha de transmissão, notadamente na primeira semana operativa. O diagrama a seguir ilustra os fluxos notáveis do SIN e os limites aplicados neste PMO.

Figura 15 – Interligações entre regiões

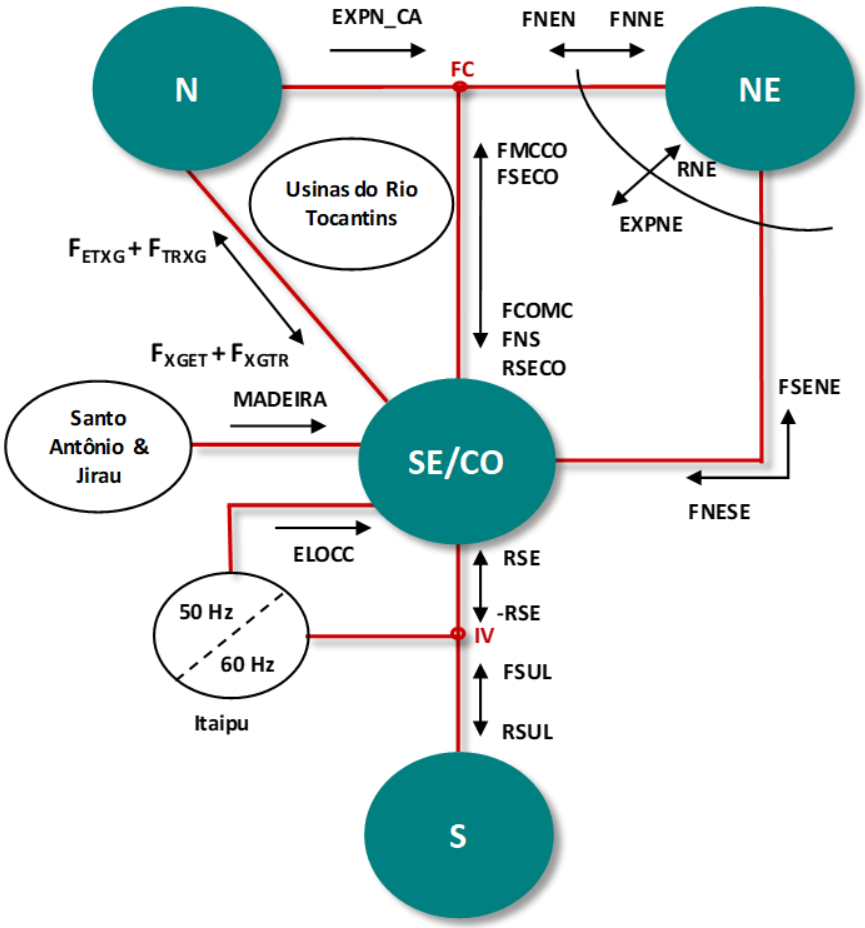

O conteúdo desta publicação foi produzido pelo ONS com base em dados e informações de conhecimento público. É de responsabilidade exclusiva dos agentes e demais interessados a obtenção de outros dados e informações, a realização de análises, estudos e avaliações para fins de tomada de decisões, definição de estratégias de atuação, assunção de compromissos e obrigações e quaisquer outras finalidades, em qualquer tempo e sob qualquer condição. É proibida a reprodução ou utilização total ou parcial do presente sem a identificação da fonte.

Tabela 4 – Limites considerados nesta semana operativa para intercâmbio de energia

Limites de Intercâmbio (MWmed)			
Fluxo	**Patamar**	**10/01 a 16/01/2026**	**Demais Semanas**
RNE	**Pesada**	11.000	11.000
	Média	11.000	11.000
	Leve	11.000	11.000
FNS	**Pesada**	3.200	3.200
	Média	3.200	3.200
	Leve	3.000	3.000
FNNE	**Pesada**	7.800	7.800
	Média	7.800	7.800
	Leve	7.800	7.800
EXPORT. NE	**Pesada**	14.700	14.700
	Média	14.700	14.700
	Leve	14.700	14.700
FMCCO	**Pesada**	5.000	5.000
	Média	5.000	5.000
	Leve	5.000	5.000
FSENE	**Pesada**	6.000	6.000
	Média	6.000	6.000
	Leve	6.000	6.000
FNS + FNESE	**Pesada**	7.700	7.700
	Média	6.367	6.367
	Leve	7.300	7.300
RSE	**Pesada**	6.495	6.495
	Média	8.795	8.795
	Leve	9.430	9.430
FORNEC. SUL	**Pesada**	7.000	7.000
	Média	7.000	7.000
	Leve	8.600	8.600

Limites de Intercâmbio (MWmed)				
Fluxo	**Patamar**	**10/01 a 16/01/2026**		**Demais Semanas**
RECEB. SUL	**Pesada**	12.000		12.000
	Média	**7.374**	**(A) (B)**	7.450
	Leve	**10.675**		11.000
ELO CC 50 Hz	**Pesada**	3.132		3.132
	Média	3.132		3.132
	Leve	3.132		3.132
ITAIPU 60 Hz	**Pesada**	7.200		7.200
	Média	7.200		7.200
	Leve	7.200		7.200
EXP. N CA	**Pesada**	8.000		8.000
	Média	8.000		8.000
	Leve	8.000		8.000
FETXG + FTRXG	**Pesada**	4.200		4.200
	Média	4.200		4.200
	Leve	4.200		4.200
FXGET + FXGTR	**Pesada**	8.000		8.000
	Média	8.000		8.000
	Leve	8.000		8.000
FNESE	**Pesada**	**5.300**		5.450
	Média	**4.417**	**(C)**	4.567
	Leve	**5.300**		5.450
FNEN	**Pesada**	6.800		6.800
	Média	**6.582**	**(D)**	6.800
	Leve	**5.758**		6.800
Ger_MADEIRA	**Pesada**	7.278		7.278
	Média	7.278		7.278
	Leve	7.278		7.278

(A) SGI 78.338-25
(B) SGI 78.344-25
(C) SGI 67.632-25
(D) SGI 80.675-25

O conteúdo desta publicação foi produzido pelo ONS com base em dados e informações de conhecimento público. É de responsabilidade exclusiva dos agentes e demais interessados a obtenção de outros dados e informações, a realização de análises, estudos e avaliações para fins de tomada de decisões, definição de estratégias de atuação, assunção de compromissos e obrigações e quaisquer outras finalidades, em qualquer tempo e sob qualquer condição. É proibida a reprodução ou utilização total ou parcial do presente sem a identificação da fonte.

3.3. Previsão de carga

A partir do fechamento da 2ª Revisão Semanal do PMO de janeiro, as projeções de carga indicam variações de -0,1% no Subsistema Sudeste/Centro-Oeste, -2,1% no Sul, 6,9% no Nordeste e 10,4% no Norte, em comparação ao mesmo mês do ano anterior.

A estimativa de fechamento da carga global na semana operativa atual (03 a 09/01) aponta, no Sistema Interligado Nacional (SIN), resultado 0,1% superior ao da semana anterior (27/12 a 02/01). Esse aumento marginal reflete, principalmente, a compensação entre a redução das temperaturas no Sudeste e Sul em relação à semana anterior e a dissipação do efeito do feriado de Ano Novo, impactando o consumo energético.

No Sudeste/Centro-Oeste, a queda de 2,9% da carga em relação à semana anterior está associada à mudança no padrão meteorológico observada após a ocorrência de temperaturas mais elevadas em São Paulo, Rio de Janeiro e Belo Horizonte, além do início do processo de retomada das atividades que tende a influenciar a dinâmica de carga nesta transição de ano. No Sul, a carga apresentou crescimento em todas as áreas, com variação de 6,2% no subsistema. Esse comportamento sugere maior influência da retomada da atividade econômica sobre a carga em comparação aos fatores meteorológicos. Ressalta-se que, no comparativo intersemanal, a variação das temperaturas máximas nas capitais do Sudeste foi mais intensa do que verificadas nas capitais do Sul, o que contribuiu para um resultado mais equilibrado do Sudeste/Centro-Oeste na comparação por subsistema. Nos subsistemas Norte e Nordeste, observou-se dinâmica semelhante, com crescimentos de 2,6% e 2,8%, respectivamente. A menor variabilidade de temperatura e precipitação nessas regiões favorece maior estabilidade meteorológica e torna mais perceptíveis os efeitos associados à retomada gradual da atividade econômica neste início de ano.

Para a próxima semana operativa (10 a 16/01), projeta-se elevação de 4,8% na carga do SIN em relação à semana atual, totalizando 85.520 MWmédios. Esse aumento está associado à continuidade da retomada da atividade econômica e a temperaturas mais elevadas nas capitais do Sudeste. Do ponto de vista meteorológico, projeta-se aumento das máximas em São Paulo (29°C para 32°C), Rio de Janeiro (32°C para 36°C) e Belo Horizonte (26°C para 29°C), além de elevação em Porto Alegre (30 °C para 32 °C) e variações pontuais em Florianópolis (29°C para 30°C) e Curitiba (26°C para 27°C). No Norte e Nordeste, as temperaturas devem se manter próximas às atuais, como em Salvador (33 °C) e Recife (31°C), com leve ajuste em Manaus (36°C para 35°C) e estabilidade em Belém (32°C), padrão típico para o período.

Tabela 5 – Evolução da carga do PMO de Janeiro de 2026

Subsistema	CARGA SEMANAL (MWmed)						CARGA MENSAL (MWmed)	
	1ª Sem	2ª Sem	3ª Sem	4ª Sem	5ª Sem	6ª Sem	jan/26	Var. (%) jan/26 -> jan/25
SE/CO	46.504	45.168	47.492	47.857	47.961	47.285	47.085	-0,1%
Sul	13.024	13.837	15.180	15.257	15.354	15.431	14.802	-2,1%
Nordeste	13.920	14.313	14.357	14.326	14.380	14.421	14.319	6,9%
Norte	8.092	8.303	8.491	8.541	8.545	8.543	8.448	10,4%
SIN	**81.540**	**81.621**	**85.520**	**85.980**	**86.240**	**85.679**	**84.655**	**1,6%**

O conteúdo desta publicação foi produzido pelo ONS com base em dados e informações de conhecimento público. É de responsabilidade exclusiva dos agentes e demais interessados a obtenção de outros dados e informações, a realização de análises, estudos e avaliações para fins de tomada de decisões, definição de estratégias de atuação, assunção de compromissos e obrigações e quaisquer outras finalidades, em qualquer tempo e sob qualquer condição. É proibida a reprodução ou utilização total ou parcial do presente sem a identificação da fonte.

3.4. Potência Hidráulica Total Disponível no SIN

O gráfico a seguir mostra a disponibilidade hidráulica total do SIN, para este mês, de acordo com o cronograma de manutenção informado pelos agentes para esta Revisão.

Figura 16 – Potência hidráulica disponível no SIN

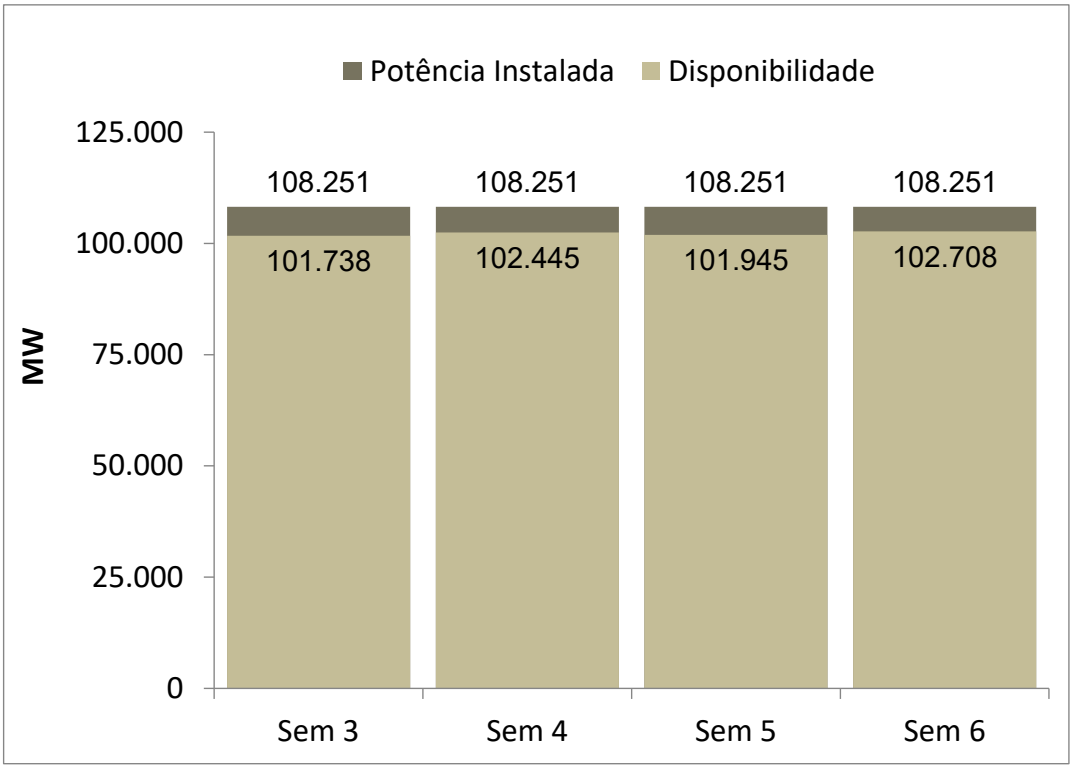

3.5. Armazenamentos Iniciais por Subsistema

Tabela 6 – Armazenamentos iniciais, por subsistema, considerados para esta semana operativa

Armazenamento (%EARmáx) - 0:00 h do dia 10/01/2026		
Subsistema	**Nível previsto na Revisão 1 do PMO Jan/2026**	**Partida informada pelos Agentes para a Revisão 2 do PMO Jan/2026**
SE/CO	43,6	43,0
S	73,9	69,6
NE	47,4	47,3
N	58,8	55,1

A primeira coluna da tabela acima corresponde ao armazenamento previsto na Revisão 1 do PMO de janeiro de 2026, para a 0:00 h do dia 10/01/2026. A segunda coluna apresenta os armazenamentos obtidos a partir dos níveis de partida informados pelos Agentes de Geração para seus aproveitamentos com reservatórios.

O conteúdo desta publicação foi produzido pelo ONS com base em dados e informações de conhecimento público. É de responsabilidade exclusiva dos agentes e demais interessados a obtenção de outros dados e informações, a realização de análises, estudos e avaliações para fins de tomada de decisões, definição de estratégias de atuação, assunção de compromissos e obrigações e quaisquer outras finalidades, em qualquer tempo e sob qualquer condição. É proibida a reprodução ou utilização total ou parcial do presente sem a identificação da fonte.

4. PRINCIPAIS RESULTADOS

4.1. Política de Operação Energética

Para esta semana operativa, está prevista a seguinte política de intercâmbio de energia entre regiões:

Região SE/CO:

- Manutenção da utilização dos recursos das bacias dos rios Grande, Paranaíba e Paraná, conforme necessidade de alocação para o atendimento à ponta de carga e controle de nível dos reservatórios;

- Minimização das defluências das UHEs Jupiá e Porto Primavera para redução de inflexibilidade hidráulica e redução do deplecionamento dos reservatórios do Grande e Paranaíba.

Região Sul:

- Geração dimensionada para controle do nível dos reservatórios, especialmente na bacia do Uruguai, e conforme necessidade de atendimento à carga.

Região NE:

- Operação hidráulica minimizada para atendimento à máxima média mensal estabelecida pela ANA para operação na faixa de atenção do reservatório de Sobradinho.

Região Norte:

- Perfil exportador em todos os patamares, com destaque para a elevação de geração hidráulica na ponta de carga;

- Geração dimensionada para atendimento à ponta de carga.

- Desligamento parcial da CF2 da UHE Tucuruí e utilização da disponibilidade de geração da UHE Belo Monte principalmente na ponta de carga.

4.2. Custo Marginal de Operação – CMO

A figura a seguir apresenta os Custos Marginais de Operação, em valores médios semanais, para as semanas operativas deste mês.

Figura 17 – CMO em valores médios

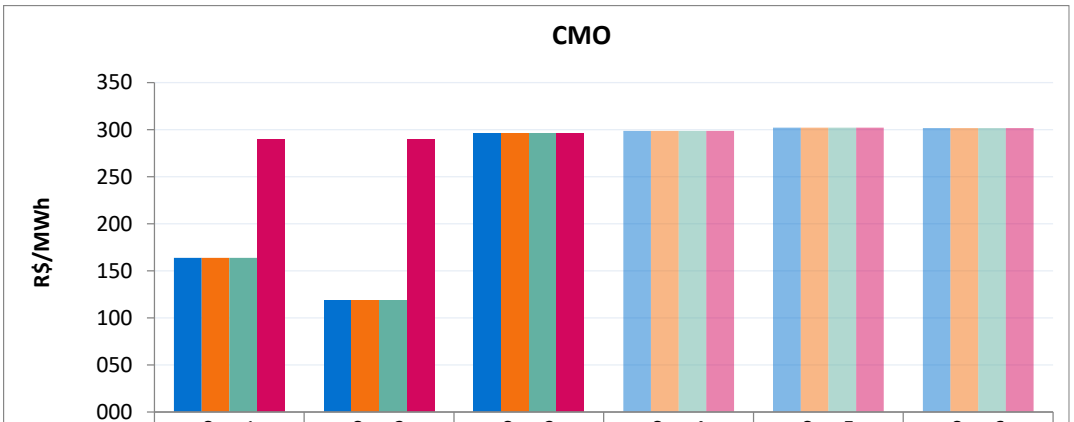

	Sem1	Sem2	Sem3	Sem4	Sem5	Sem6
Sudeste	163,88	119,10	296,18	298,67	302,26	301,84
Sul	163,88	119,10	296,18	298,67	302,26	301,84
Nordeste	163,88	119,10	295,73	298,67	302,26	301,84
Norte	289,25	289,25	296,18	298,67	302,26	301,84

O conteúdo desta publicação foi produzido pelo ONS com base em dados e informações de conhecimento público. É de responsabilidade exclusiva dos agentes e demais interessados a obtenção de outros dados e informações, a realização de análises, estudos e avaliações para fins de tomada de decisões, definição de estratégias de atuação, assunção de compromissos e obrigações e quaisquer outras finalidades, em qualquer tempo e sob qualquer condição. É proibida a reprodução ou utilização total ou parcial do presente sem a identificação da fonte.

A tabela a seguir apresenta o custo marginal de operação, por subsistema e patamar de carga, para a próxima semana operativa.

Tabela 7 – CMO para esta semana operativa

Patamares de Carga	CMO (R$/MWh)			
	SE/CO	S	NE	N
Pesada	300,56	300,56	300,56	300,56
Média	296,38	296,38	295,36	296,38
Leve	293,89	293,89	293,89	293,89
Média Semanal	296,18	296,18	295,73	296,18

4.3. Energia Armazenada

O processo de otimização realizado pelo programa DECOMP indicou os armazenamentos mostrados na figura a seguir para as próximas semanas operativas do mês de janeiro/2026.

Figura 18 – Energias Armazenadas nas semanas operativas do mês de janeiro/2026

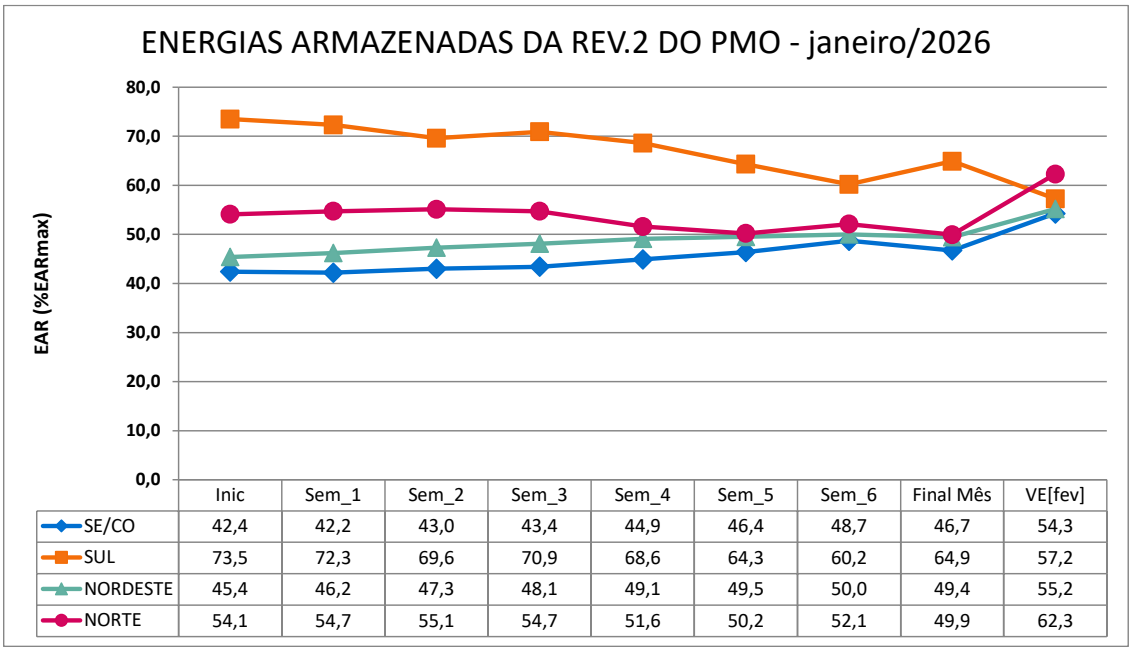

	Inic	Sem_1	Sem_2	Sem_3	Sem_4	Sem_5	Sem_6	Final Mês	VE[fev]
SE/CO	42,4	42,2	43,0	43,4	44,9	46,4	48,7	46,7	54,3
SUL	73,5	72,3	69,6	70,9	68,6	64,3	60,2	64,9	57,2
NORDESTE	45,4	46,2	47,3	48,1	49,1	49,5	50,0	49,4	55,2
NORTE	54,1	54,7	55,1	54,7	51,6	50,2	52,1	49,9	62,3

Os armazenamentos da figura anterior estão expressos em percentual da Energia Armazenável Máxima de cada subsistema, que são mostradas na tabela a seguir.

Tabela 8 – Energia Armazenável Máxima por subsistema no PMO de Janeiro/2026

ENERGIA ARMAZENÁVEL MÁXIMA (MWmed)		
Subsistema	janeiro	fevereiro
SE/CO	205.569	205.569
S	20.458	20.458
NE	51.718	51.718
N	15.329	14.727

O conteúdo desta publicação foi produzido pelo ONS com base em dados e informações de conhecimento público. É de responsabilidade exclusiva dos agentes e demais interessados a obtenção de outros dados e informações, a realização de análises, estudos e avaliações para fins de tomada de decisões, definição de estratégias de atuação, assunção de compromissos e obrigações e quaisquer outras finalidades, em qualquer tempo e sob qualquer condição. É proibida a reprodução ou utilização total ou parcial do presente sem a identificação da fonte.

5. GERAÇÃO TÉRMICA

A Figura 19 apresenta, para cada subsistema do SIN, o despacho térmico por modalidade indicado pelo DECOMP para esta semana operativa.

Figura 19 – Geração térmica para a próxima semana operativa

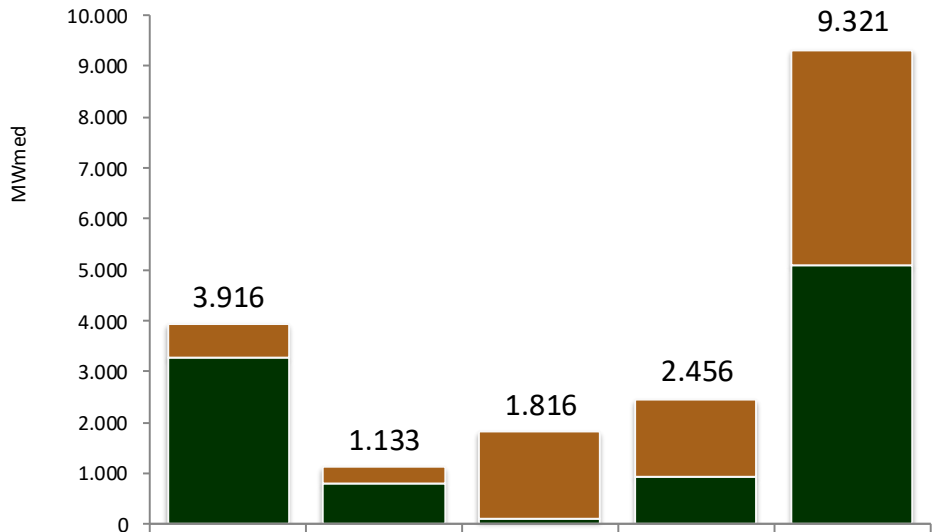

	SE/CO	SUL	NE	NORTE	SIN
TOTAL	3.916	1.133	1.816	2.456	9.321
ORDEM DE MÉRITO	638	353	1717	1521	4229
RESTRIÇÃO ELÉTRICA	0	0	0	0	0
INFLEXIBILIDADE	3278	780	99	935	5092

Na tabela abaixo segue a Indicação de despacho antecipado por ordem de mérito de custo para a semana de 14/03/2026 a 20/03/2026.

Tabela 8 – UTEs com contrato de combustível GNL

UTE			Benefício (R$/MWh)			Despacho antecipado por mérito		
Nome	Código	CVU (R$/MWh)	Carga Pesada	Carga Média	Carga Leve	Carga Pesada	Carga Média	Carga Leve
SANTA CRUZ	86	319,46	241,19	232,28	226,97	Não	Não	Não
PSERGIPE I	224	300,35	238,49	229,74	226,42	Não	Não	Não

Assim sendo, não há previsão de despacho antecipado por ordem de mérito de custo para as UTE Santa Cruz, Luiz O. R. Melo e Porto Sergipe I, para a semana de 14/03/2026 a 20/03/2026.

O conteúdo desta publicação foi produzido pelo ONS com base em dados e informações de conhecimento público. É de responsabilidade exclusiva dos agentes e demais interessados a obtenção de outros dados e informações, a realização de análises, estudos e avaliações para fins de tomada de decisões, definição de estratégias de atuação, assunção de compromissos e obrigações e quaisquer outras finalidades, em qualquer tempo e sob qualquer condição. É proibida a reprodução ou utilização total ou parcial do presente sem a identificação da fonte.

6. RESUMO DOS RESULTADOS DO PMO

As figuras a seguir apresentam um resumo dos resultados da Revisão 2 do PMO de aneiro/2026, com informações da Energia Natural Afluente (ENA), da Energia Armazenada (EAR) e do Custo Marginal de Operação (CMO) nos subsistemas do Sistema Interligado Nacional (SIN). São apresentados os valores semanais observados e previstos e o valor esperado dos cenários gerados para o mês de fevereiro/2026.

Figura 20 – Resumo de janeiro/2026 para o Subsistema Sudeste/Centro-Oeste

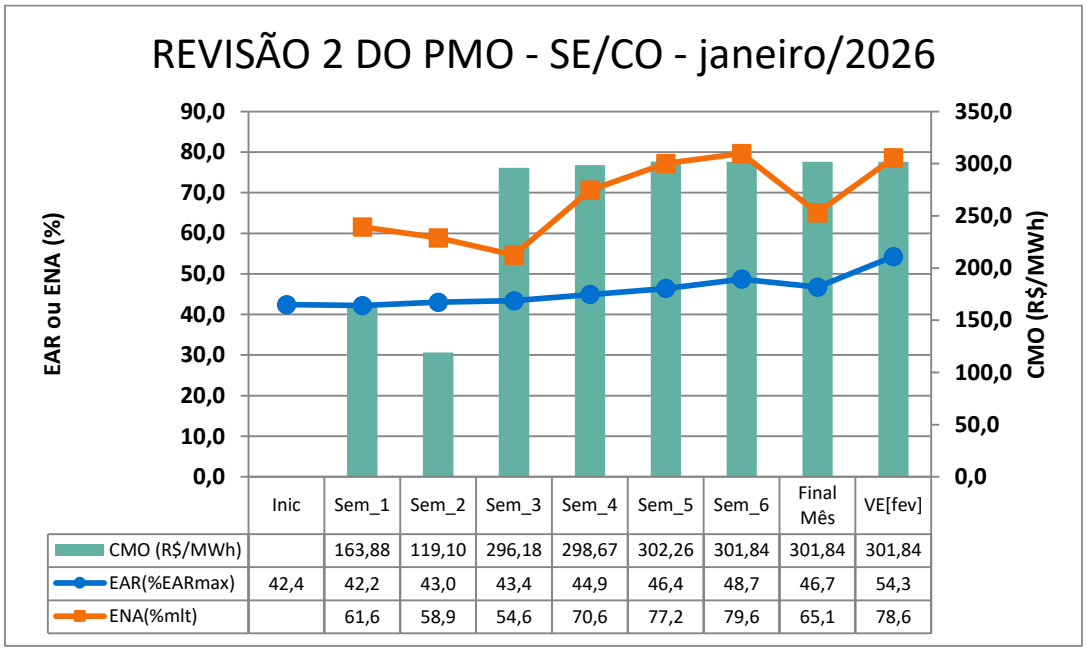

	Inic	Sem_1	Sem_2	Sem_3	Sem_4	Sem_5	Sem_6	Final Mês	VE[fev]
CMO (R$/MWh)		163,88	119,10	296,18	298,67	302,26	301,84	301,84	301,84
EAR(%EARmax)	42,4	42,2	43,0	43,4	44,9	46,4	48,7	46,7	54,3
ENA(%mlt)		61,6	58,9	54,6	70,6	77,2	79,6	65,1	78,6

Figura 21 – Resumo de janeiro/2026 para o Subsistema Sul

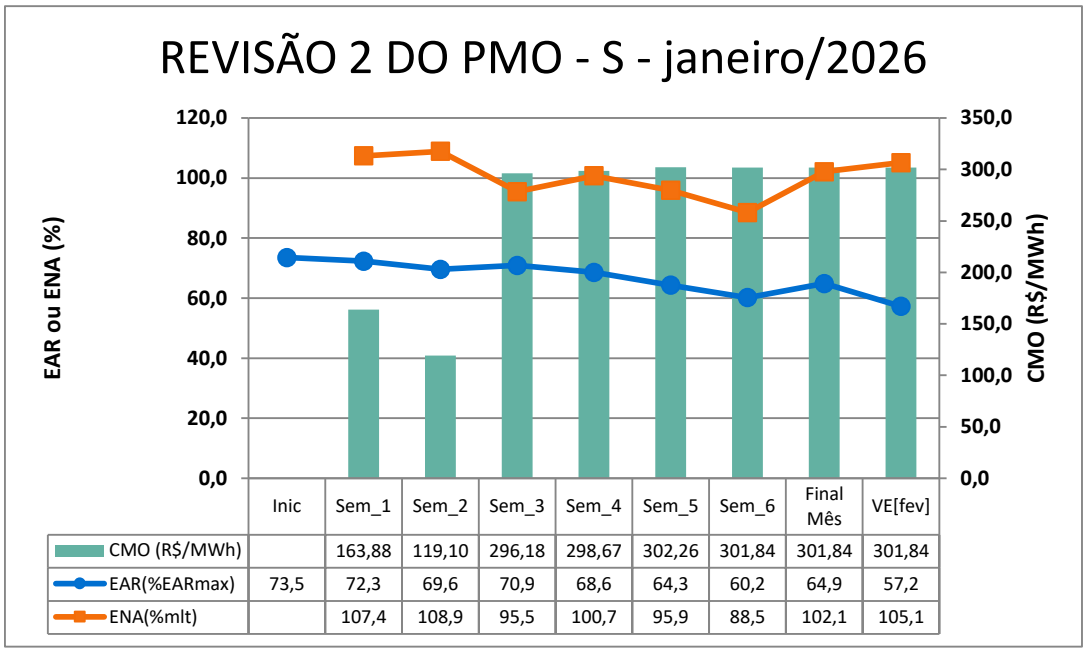

	Inic	Sem_1	Sem_2	Sem_3	Sem_4	Sem_5	Sem_6	Final Mês	VE[fev]
CMO (R$/MWh)		163,88	119,10	296,18	298,67	302,26	301,84	301,84	301,84
EAR(%EARmax)	73,5	72,3	69,6	70,9	68,6	64,3	60,2	64,9	57,2
ENA(%mlt)		107,4	108,9	95,5	100,7	95,9	88,5	102,1	105,1

O conteúdo desta publicação foi produzido pelo ONS com base em dados e informações de conhecimento público. É de responsabilidade exclusiva dos agentes e demais interessados a obtenção de outros dados e informações, a realização de análises, estudos e avaliações para fins de tomada de decisões, definição de estratégias de atuação, assunção de compromissos e obrigações e quaisquer outras finalidades, em qualquer tempo e sob qualquer condição. É proibida a reprodução ou utilização total ou parcial do presente sem a identificação da fonte.

Figura 22 – Resumo de janeiro/2026 para o Subsistema Nordeste

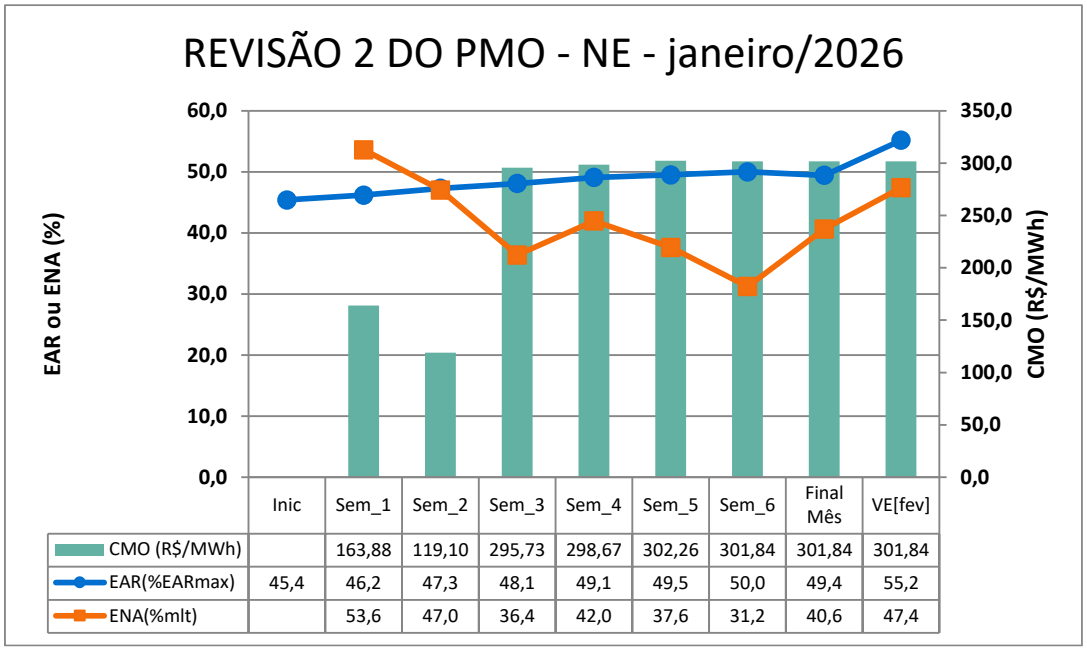

	Inic	Sem_1	Sem_2	Sem_3	Sem_4	Sem_5	Sem_6	Final Mês	VE[fev]
CMO (R$/MWh)		163,88	119,10	295,73	298,67	302,26	301,84	301,84	301,84
EAR(%EARmax)	45,4	46,2	47,3	48,1	49,1	49,5	50,0	49,4	55,2
ENA(%mlt)		53,6	47,0	36,4	42,0	37,6	31,2	40,6	47,4

Figura 23 – Resumo de janeiro/2026 para o Subsistema Norte

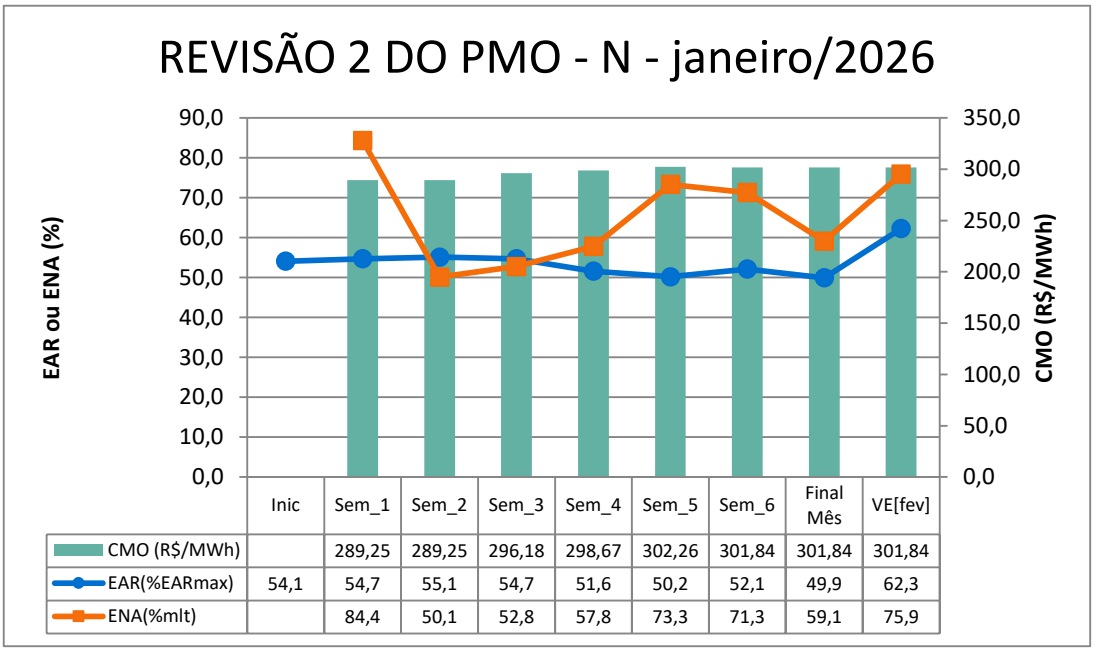

	Inic	Sem_1	Sem_2	Sem_3	Sem_4	Sem_5	Sem_6	Final Mês	VE[fev]
CMO (R$/MWh)		289,25	289,25	296,18	298,67	302,26	301,84	301,84	301,84
EAR(%EARmax)	54,1	54,7	55,1	54,7	51,6	50,2	52,1	49,9	62,3
ENA(%mlt)		84,4	50,1	52,8	57,8	73,3	71,3	59,1	75,9

O conteúdo desta publicação foi produzido pelo ONS com base em dados e informações de conhecimento público. É de responsabilidade exclusiva dos agentes e demais interessados a obtenção de outros dados e informações, a realização de análises, estudos e avaliações para fins de tomada de decisões, definição de estratégias de atuação, assunção de compromissos e obrigações e quaisquer outras finalidades, em qualquer tempo e sob qualquer condição. É proibida a reprodução ou utilização total ou parcial do presente sem a identificação da fonte.

7. ARMAZENAMENTOS OPERATIVOS

Para uma melhor avaliação de diversos cenários hidrometeorológicos, notadamente, aqueles de curto prazo e suas influências nas previsões de vazões nos subsistemas, os resultados desta revisão do PMO contemplam cenários de afluências visando melhor representar a ocorrência de precipitação e, consequentemente, seus efeitos sobre as afluências e armazenamentos.

Apresentamos a seguir as correspondentes energias naturais afluentes e os resultados obtidos com a aplicação do cenário de afluência utilizado no estudo.

Tabela 9 – Previsão de ENA do caso de valor esperado das previsões de afluência

Subsistema	ENERGIAS NATURAIS AFLUENTES			
	Previsão Semanal		Previsão Mensal	
	(MWmed)	%MLT	(MWmed)	%MLT
SE/CO	35.944	55	42.820	65
Sul	7.231	96	7.731	102
Nordeste	4.881	36	5.452	41
Norte	8.324	53	9.333	59

Tabela 10 – Previsão de %EARmáx para o final do mês

Subsistema	% EARmáx 09/01	% EARmáx - 31/01
	NÍVEL INICIAL	NÍVEL PMO
SE/CO	43,0	46,7
Sul	69,6	63,7
Nordeste	47,3	49,6
Norte	55,1	50,5

O conteúdo desta publicação foi produzido pelo ONS com base em dados e informações de conhecimento público. É de responsabilidade exclusiva dos agentes e demais interessados a obtenção de outros dados e informações, a realização de análises, estudos e avaliações para fins de tomada de decisões, definição de estratégias de atuação, assunção de compromissos e obrigações e quaisquer outras finalidades, em qualquer tempo e sob qualquer condição. É proibida a reprodução ou utilização total ou parcial do presente sem a identificação da fonte.

8. RESERVATÓRIOS EQUIVALENTES DE ENERGIA

A seguir são apresentadas as previsões de Energia Natural Afluente para a próxima semana operativa e para o mês de janeiro, bem como as previsões de Energia Armazenada nos Reservatórios Equivalentes de Energia – REE, desta revisão do PMO de Janeiro de 2026.

Tabela 11 – Previsão de ENA por REE

Valor Esperado das Energias Naturais Afluentes				
REE	Previsão Semanal		Previsão Mensal	
	10/01/2026 a 16/01/2026		jan-26	
	(MWmed)	%MLT	(MWmed)	%MLT
Sudeste	4.461	43	4.904	47
Madeira	8.332	103	9.312	115
Teles Pires	2.938	85	2.927	85
Itaipu	3.862	115	4.900	146
Paraná	14.246	39	17.134	47
Paranapanema	2.102	58	3.652	101
Sul	4.772	138	4.863	140
Iguaçu	2.459	60	2.868	70
Nordeste	4.881	36	5.452	41
Norte	4.570	48	4.989	52
Belo Monte	3.429	59	3.903	68
Manaus	330	65	476	94

Tabela 12 – Previsão de %EARmáx por REE

% Energia Armazenável Máxima		
REE	Previsão Semanal	Previsão Mensal
	16-jan	31-jan
	(%EARmáx)	(%EARmáx)
Sudeste	52,6	54,3
Madeira	33,5	31,2
Teles Pires	10,6	8,0
Itaipu	0,8	59,2
Paraná	38,9	42,2
Paranapanema	63,1	70,9
Sul	79,8	78,6
Iguaçu	62,1	49,2
Nordeste	48,1	49,6
Norte	55,1	50,2
Belo Monte	23,1	22,3
Manaus	48,3	57,1

O conteúdo desta publicação foi produzido pelo ONS com base em dados e informações de conhecimento público. É de responsabilidade exclusiva dos agentes e demais interessados a obtenção de outros dados e informações, a realização de análises, estudos e avaliações para fins de tomada de decisões, definição de estratégias de atuação, assunção de compromissos e obrigações e quaisquer outras finalidades, em qualquer tempo e sob qualquer condição. É proibida a reprodução ou utilização total ou parcial do presente sem a identificação da fonte.

9. DESPACHO TÉRMICO POR MODALIDADE, PATAMAR DE CARGA E USINA

Nas tabelas abaixo, a diferenciação entre geração por inflexibilidade e por ordem de mérito tem caráter informativo, com o objetivo de detalhar a informação de inflexibilidade enviada pelos respectivos agentes para esta revisão do PMO. Ressalta-se que nas etapas de Programação Diária e Tempo Real, o montante despachado nas usinas termelétricas indicadas por ordem de mérito é plenamente intitulado como ordem de mérito.

REGIÃO SUDESTE/CENTRO-OESTE																	
Térmicas Potência (MW)	Combustível	CVU (R$/MWh)	Inflexibilidade			Ordem de Mérito			Total Mérito e INFL.			Razão Elétrica			Total UTE		
			P	M	L	P	M	L	P	M	L	P	M	L	P	M	L
ATLAN_CSA (255)	Resíduos	0,00	161,4	161,4	161,4				161,4	161,4	161,4				161,4	161,4	161,4
ATLANTICO (235)	Resíduos	0,00	3,3	3,3	3,3				3,3	3,3	3,3				3,3	3,3	3,3
DAIA (44)	Diesel	---															
PALMEIR_GO (176)	Diesel	---															
PAULINIA (16)	Gás	---															
TNORTE 2 (349)	Óleo	---															
W.ARJONA O (177)	Diesel	---															
XAVANTES (54)	Diesel	---															
ANGRA 2 (1350)	Nuclear	20,12	1080,0	1131,0	1223,0	0,0	0,0	0,0	1080,0	1131,0	1223,0				1080,0	1131,0	1223,0
ANGRA 1 (640)	Nuclear	31,17	460,0	460,0	460,0	0,0	0,0	0,0	460,0	460,0	460,0				460,0	460,0	460,0
M.AZUL (566)	Gás	128,17	478,0	478,0	478,0	87,5	87,5	87,5	565,5	565,5	565,5				565,5	565,5	565,5
O.PINTADA (50)	Biomassa	152,33				50,0	50,0	50,0	50,0	50,0	50,0				50,0	50,0	50,0
UTE STA VI (41)	Biomassa	164,56				0,0	0,0	0,0									
ST.CRUZ 34 (436)	Óleo	310,41															
BAIXADA FL (530)	Gás	314,89	230,0	230,0	230,0				230,0	230,0	230,0				230,0	230,0	230,0
SANTA CRUZ (500)	GNL	319,46				500,0	500,0	500,0	500,0	500,0	500,0				500,0	500,0	500,0
CUBATAO (216)	Gás	342,53	200,0	200,0	200,0				200,0	200,0	200,0				200,0	200,0	200,0
UTE GNA II (1673)	Gás	445,95															
UTE GNA I (1338)	Gás	617,01															
KARKEY 013 (259)	Gás	703,10	31,0	31,0	31,0				31,0	31,0	31,0				31,0	31,0	31,0
KARKEY 019 (116)	Gás	703,10															
T.LAGOAS (350)	Gás	766,64															
CUIABA CC (529)	Gás	825,02															
PORSUD I (116)	Gás	834,61															
PORSUD II (78)	Gás	836,73															
W.ARJONA (177)	Gás	841,11															
IBIRITE (226)	Gás	841,37															
TERMORIO (989)	Gás	842,32	290,0	290,0	290,0				290,0	290,0	290,0				290,0	290,0	290,0
NORTEFLU (826)	Gás	966,31															
VIANA (175)	Óleo	975,44															
LORM_PCS (36)	Gás	1004,44 / 914,11 *															
POVOACAO I (75)	Gás	1004,44 / 958,82 *															
T.MACAE (922)	Gás	1011,95	260,0	260,0	260,0				260,0	260,0	260,0				260,0	260,0	260,0
SEROPEDICA (360)	Gás	1068,51	17,8	9,7					17,8	9,7					17,8	9,7	0,0
J.FORA (87)	Gás	1078,63															
VIANA I (37)	Gás	1096,46															
NPIRATINGA (572)	Gás	1294,25															
TOTAL SE/CO (14576)			3211,5	3254,4	3336,7	637,5	637,5	637,5	3849,0	3891,9	3974,2	0,0	0,0	0,0	3849,0	3891,9	3974,2

REGIÃO SUL																	
Térmicas Potência (MW)	Combustível	CVU (R$/MWh)	Inflexibilidade			Ordem de Mérito			Total Mérito e INFL.			Razão Elétrica			Total UTE		
			P	M	L	P	M	L	P	M	L	P	M	L	P	M	L
B.BONITA I (10)	Gás	---															
URUGUAIANA (640)	Gás	---															
PAMPA SUL (345)	Carvão	105,94				345,0	345,0	345,0	345,0	345,0	345,0				345,0	345,0	345,0
SAO SEPE (8)	Biomassa	118,84				8,0	8,0	8,0	8,0	8,0	8,0				8,0	8,0	8,0
J.LACER. C (330)	Carvão	341,04	300,0	300,0	300,0				300,0	300,0	300,0				300,0	300,0	300,0
J.LACER. B (220)	Carvão	397,24	110,0	110,0	110,0				110,0	110,0	110,0				110,0	110,0	110,0
J.LAC. A2 (110)	Carvão	406,63	50,0	50,0	50,0				50,0	50,0	50,0				50,0	50,0	50,0
J.LAC. A1 (80)	Carvão	475,13															
CANDIOTA_3 (350)	Carvão	519,71	320,0	320,0	320,0				320,0	320,0	320,0				320,0	320,0	320,0
ARAUCARIA (484)	Gás	969,68															
CANOAS (249)	Gás	1375,20															
TOTAL SUL (2826)			780,0	780,0	780,0	353,0	353,0	353,0	1133,0	1133,0	1133,0	0,0	0,0	0,0	1133,0	1133,0	1133,0

O conteúdo desta publicação foi produzido pelo ONS com base em dados e informações de conhecimento público. É de responsabilidade exclusiva dos agentes e demais interessados a obtenção de outros dados e informações, a realização de análises, estudos e avaliações para fins de tomada de decisões, definição de estratégias de atuação, assunção de compromissos e obrigações e quaisquer outras finalidades, em qualquer tempo e sob qualquer condição. É proibida a reprodução ou utilização total ou parcial do presente sem a identificação da fonte.

REGIÃO NORDESTE

Térmicas Potência (MW)	Combustível	CVU (R$/MWh)	Inflexibilidade			Ordem de Mérito			Total Mérito e INFL.			Razão Elétrica			Total UTE		
			P	M	L	P	M	L	P	M	L	P	M	L	P	M	L
MARACANAU (168)	Óleo	---															
PETROLINA (136)	Óleo	---															
ERB CANDEI (17)	Biomassa	118,93				12,0	12,0	12,0	12,0	12,0	12,0				12,0	12,0	12,0
PROSP_I (28)	Gás	224,31				18,7	18,7	18,7	18,7	18,7	18,7				18,7	18,7	18,7
PROSP_III (56)	Gás	228,55				56,0	56,0	56,0	56,0	56,0	56,0				56,0	56,0	56,0
PROSP_II (37)	Gás	271,14				37,3	37,3	37,3	37,3	37,3	37,3				37,3	37,3	37,3
PSERGIPE I (1593)	GNL	300,35				1593,0	1593,0	1593,0	1593,0	1593,0	1593,0				1593,0	1593,0	1593,0
P.PECEM1 (720)	Carvão	306,64															
P.PECEM2 (365)	Carvão	317,47															
VALE ACU (110)	Gás	450,86															
PERNAMBU_3 (201)	Óleo	741,18															
TERMOPE (550)	Gás	806,73															
SUAPE II (381)	Óleo	875,88															
T.BAHIA (186)	Gás	984,89	95,0	95,0	95,0				95,0	95,0	95,0				95,0	95,0	95,0
GLOBAL I (136)	Óleo	1104,92															
GLOBAL II (136)	Óleo	1104,92															
TERMOCABO (50)	Óleo	1504,27															
POTIGUAR (53)	Diesel	1838,20															
POTIGUAR_3 (66)	Diesel	1838,20															
TERMONE (171)	Óleo	1840,95															
TERMOPB (171)	Óleo	1840,95															
CAMPINA_GR (169)	Óleo	2085,48															
TERMOCEARA (223)	Óleo	2237,72	6,3	5,9					6,3	5,9					6,3	5,9	0,0
C.MURICY 2 (144)	Óleo	2295,76															
PECEM 2 (144)	Óleo	2319,64															
TOTAL NE (5725)			101,3	100,9	95,0	1717,0	1717,0	1717,0	1818,3	1817,9	1812,0	0,0	0,0	0,0	1818,3	1817,9	1812,0

REGIÃO NORTE

Térmicas Potência (MW)	Combustível	CVU (R$/MWh)	Inflexibilidade			Ordem de Mérito			Total Mérito e INFL.			Razão Elétrica			Total UTE		
			P	M	L	P	M	L	P	M	L	P	M	L	P	M	L
MARANHAO3 (519)	Gás	116,10	490,0	490,0	490,0	10,8	14,6	22,1	500,8	504,6	512,1				500,8	504,6	512,1
APARECIDA (166)	Gás	149,00	75,0	75,0	75,0	77,0	75,3	81,3	152,0	150,3	156,3				152,0	150,3	156,3
JARAQUI (75)	Gás	149,00	14,5	14,5	14,5	48,5	48,5	48,5	63,0	63,0	63,0				63,0	63,0	63,0
PIRARUCU (73)	Gás	149,00	16,5	16,5	16,5	50,5	50,5	50,5	67,0	67,0	67,0				67,0	67,0	67,0
PORAQUE (85)	Gás	149,00	16,5	16,5	16,5	63,5	63,5	63,5	80,0	80,0	80,0				80,0	80,0	80,0
TAMBAQUI (93)	Gás	149,00	17,4	17,4	17,4	45,6	45,6	45,6	63,0	63,0	63,0				63,0	63,0	63,0
TUCUNARE (73)	Gás	149,00	16,5	16,5	16,5	48,5	48,5	48,5	65,0	65,0	65,0				65,0	65,0	65,0
UTE MAUA 3 (591)	Gás	149,00	264,0	264,0	264,0	326,8	326,8	326,8	590,8	590,8	590,8				590,8	590,8	590,8
PARNAIBA_V (386)	Vapor	231,22				239,0	239,0	239,0	239,0	239,0	239,0				239,0	239,0	239,0
JAGUATI II (141)	Gás	289,25				126,2	126,2	126,2	126,2	126,2	126,2				126,2	126,2	126,2
MARANHAO V (338)	Gás	293,89				329,7	331,4	178,3	329,7	331,4	178,3				329,7	331,4	178,3
MARANHAOIV (338)	Gás	293,89				329,7	331,4	0,0	329,7	331,4					329,7	331,4	0,0
N.VENECIA2 (270)	Gás	308,35															
P. ITAQUI (360)	Carvão	309,35															
BONFIM (12)	Biomassa	555,69	5,0	5,0	5,0				5,0	5,0	5,0				5,0	5,0	5,0
CANTA (12)	Biomassa	555,69	5,0	5,0	5,0				5,0	5,0	5,0				5,0	5,0	5,0
PAU RAINHA (12)	Biomassa	555,69	5,0	5,0	5,0				5,0	5,0	5,0				5,0	5,0	5,0
SANTA LUZ (12)	Biomassa	555,69	5,0	5,0	5,0				5,0	5,0	5,0				5,0	5,0	5,0
PARNAIB_IV (56)	Gás	759,24															
BBF BALIZA (18)	Biomassa	876,44	5,0	5,0	5,0				5,0	5,0	5,0				5,0	5,0	5,0
GERAMAR1 (166)	Óleo	900,08															
GERAMAR2 (166)	Óleo	900,08															
M.C.SUCUBA (42)	Diesel	1721,10															
PALMAPLAN (12)	Biomassa	1840,09															
TOTAL NORTE (4303)			935,4	935,4	935,4	1695,8	1701,3	1230,3	2631,2	2636,7	2165,7	0,0	0,0	0,0	2631,2	2636,7	2165,7

O conteúdo desta publicação foi produzido pelo ONS com base em dados e informações de conhecimento público. É de responsabilidade exclusiva dos agentes e demais interessados a obtenção de outros dados e informações, a realização de análises, estudos e avaliações para fins de tomada de decisões, definição de estratégias de atuação, assunção de compromissos e obrigações e quaisquer outras finalidades, em qualquer tempo e sob qualquer condição. É proibida a reprodução ou utilização total ou parcial do presente sem a identificação da fonte.