1. APRESENTAÇÃO

Na semana de 03/05 a 09/05 houve precipitação nas bacias dos rios Jacuí, Uruguai e Madeira.

Na semana de 10/05 a 16/05 deve ocorrer precipitação nas bacias dos rios Jacuí, Uruguai, Iguaçu, Paranapanema e na incremental a UHE Itaipu. As demais bacias hidrográficas do SIN não devem registrar precipitação significativa prevista.

Os valores médios semanais do Custo Marginal de Operação – CMO dos subsistemas do SIN sofreram as seguintes alterações em relação à semana anterior:

- SE/CO: de R$ 244,95/MWh para R$ 256,93/MWh
- Sul: de R$ 249,34/MWh para R$ 288,94/MWh
- Nordeste: de R$ 0,00/MWh para R$ 216,13/MWh
- Norte: de R$ 0,00/MWh para R$ 216,13/MWh

Desde o dia 01/01/2020, o despacho por ordem de mérito é indicado diariamente pelos resultados do modelo DESSEM. Assim, o despacho por ordem de mérito semanal, conforme publicado nesse documento, tem caráter apenas informativo. Da mesma forma, desde o dia 01/01/2021, a formação de preço deixou o formato semanal/patamar de carga e passou a ser horário, de acordo também com os resultados do modelo DESSEM.

2. NOTÍCIAS

Nos dias 29 e 30 de maio será realizada a reunião de elaboração do PMO de Junho de 2025, com transmissão ao vivo através do site do ONS.

3. INFORMAÇÕES CONJUNTURAIS PARA ELABORAÇÃO DO PMO

3.1. Informações hidrometeorológicas

3.1.1. Condições antecedentes

A atuação de área de instabilidade e o avanço de uma frente fria pela região Sul ocasionaram precipitação próxima da média nas bacias dos rios Jacuí, Uruguai e Madeira (Figura 1). A condição de céu claro predominou nas demais bacias do SIN.

O conteúdo desta publicação foi produzido pelo ONS com base em dados e informações de conhecimento público. É de responsabilidade exclusiva dos agentes e demais interessados a obtenção de outros dados e informações, a realização de análises, estudos e avaliações para fins de tomada de decisões, definição de estratégias de atuação, assunção de compromissos e obrigações e quaisquer outras finalidades, em qualquer tempo e sob qualquer condição. É proibida a reprodução ou utilização total ou parcial do presente sem a identificação da fonte.

Figura 1 – Precipitação observada (mm) no período de 03 a 08/05/2025

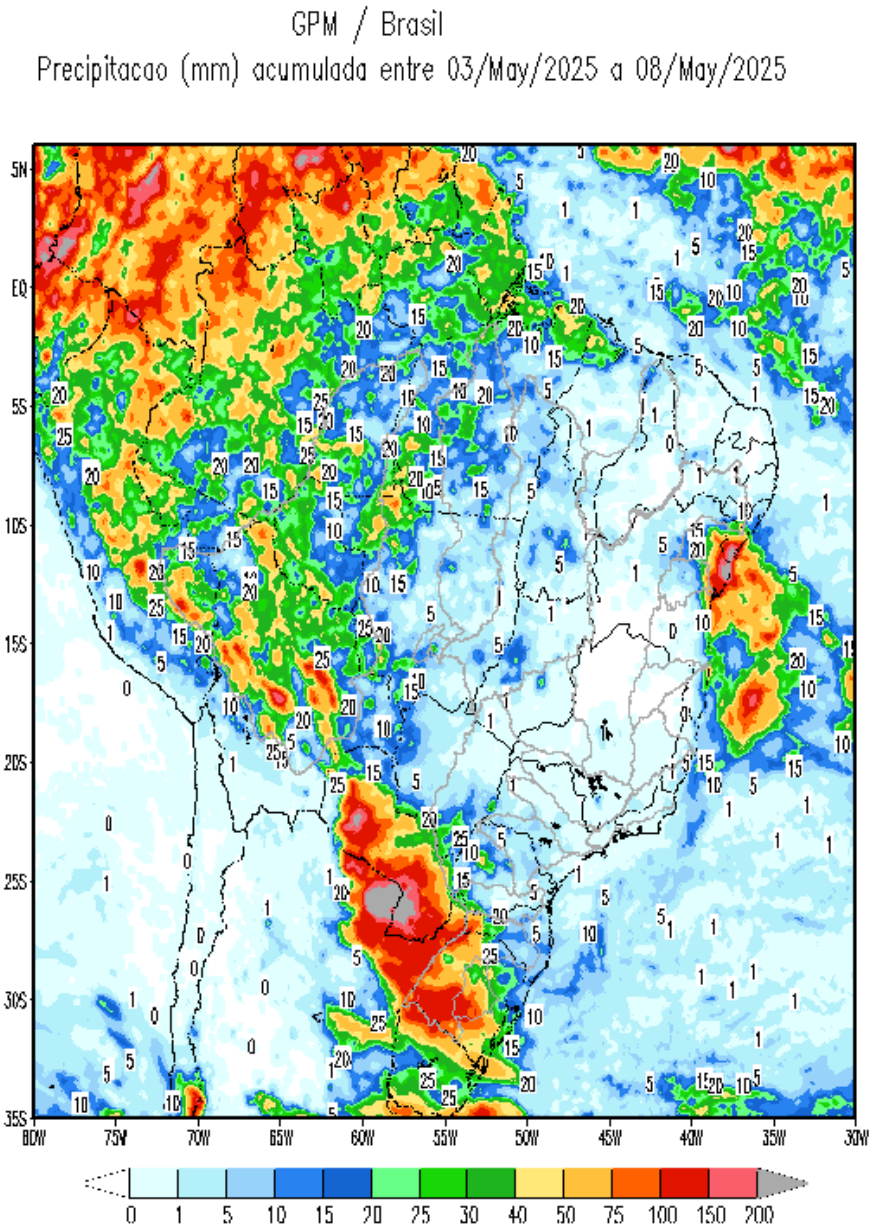

A Tabela 1 apresenta as energias naturais afluentes das semanas recentes. São apresentados os valores verificados na semana 26/04/2025 a 02/05/2025 e os estimados para fechamento da semana de 03/05/2025 a 09/05/2025.

Tabela 1 – Tendência hidrológica da ENA da Revisão 2 de Maio/2025

Revisão 2 do PMO de Maio/2025 - ENAs				
Subsistema	26/04 a 02/05/2025		03/05 a 09/05/2025	
	MWmed	%MLT	MWmed	%MLT
SE/CO	45.899	91	41.352	104
S	2.813	39	2.483	29
NE	3.581	36	4.145	60
N	19.068	75	16.522	81

O conteúdo desta publicação foi produzido pelo ONS com base em dados e informações de conhecimento público. É de responsabilidade exclusiva dos agentes e demais interessados a obtenção de outros dados e informações, a realização de análises, estudos e avaliações para fins de tomada de decisões, definição de estratégias de atuação, assunção de compromissos e obrigações e quaisquer outras finalidades, em qualquer tempo e sob qualquer condição. É proibida a reprodução ou utilização total ou parcial do presente sem a identificação da fonte.

3.1.2. Previsão para a próxima semana

A passagem de uma frente fria pela Região Sul e litoral do Sudeste no início da próxima semana operativa ocasiona precipitação nas bacias dos rios Jacuí, Uruguai, Iguaçu, Paranapanema e na incremental a UHE Itaipu, com totais entre a média e abaixo da média (Figura 2). As demais bacias hidrográficas do SIN não devem registrar precipitação significativa prevista.

Figura 2 - Precipitação acumulada prevista pelo modelo ECMWF - período de 10 a 16/05/2025

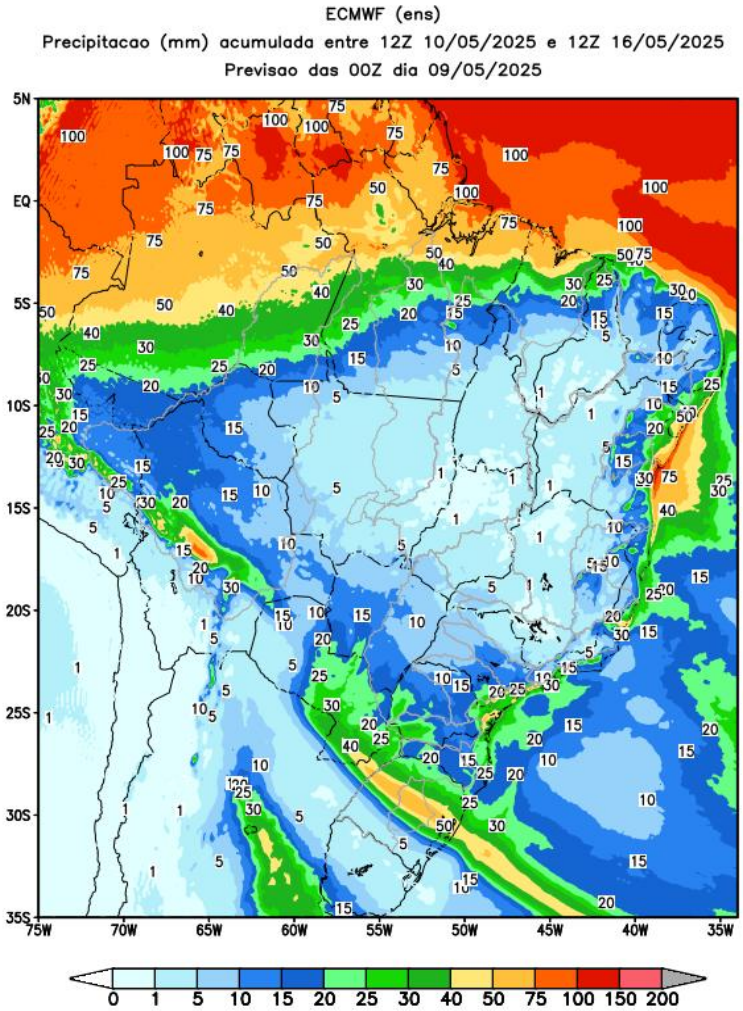

Em comparação com os valores estimados para a semana em curso, prevê-se para a próxima semana operativa ascensão nas afluências do subsistema Sul e recessão nas afluências dos subsistemas Sudeste/Centro-Oeste, Nordeste e Norte. A previsão mensal para maio indica a ocorrência de afluências abaixo da média histórica para todos os subsistemas.

Tabela 2 – Previsão de ENAs da Revisão 2 de Maio/2025

Revisão 2 do PMO de Maio/2025 - ENAs previstas				
Subsistema	10/05 a 16/05/2025		Mês de maio	
	MWmed	%MLT	MWmed	%MLT
SE/CO	33.960	85	34.389	86
S	3.060	36	2.892	34
NE	3.351	49	2.969	43
N	13.699	67	13.121	64

O conteúdo desta publicação foi produzido pelo ONS com base em dados e informações de conhecimento público. É de responsabilidade exclusiva dos agentes e demais interessados a obtenção de outros dados e informações, a realização de análises, estudos e avaliações para fins de tomada de decisões, definição de estratégias de atuação, assunção de compromissos e obrigações e quaisquer outras finalidades, em qualquer tempo e sob qualquer condição. É proibida a reprodução ou utilização total ou parcial do presente sem a identificação da fonte.

As figuras a seguir ilustram as ENAs semanais verificadas e previstas para as Revisões 1 e 2 do PMO de Maio/2025.

Figura 3 - Energias Naturais Afluentes ao Subsistema Sudeste/Centro-Oeste das Revisões 1 e 2 do PMO de Maio/2025

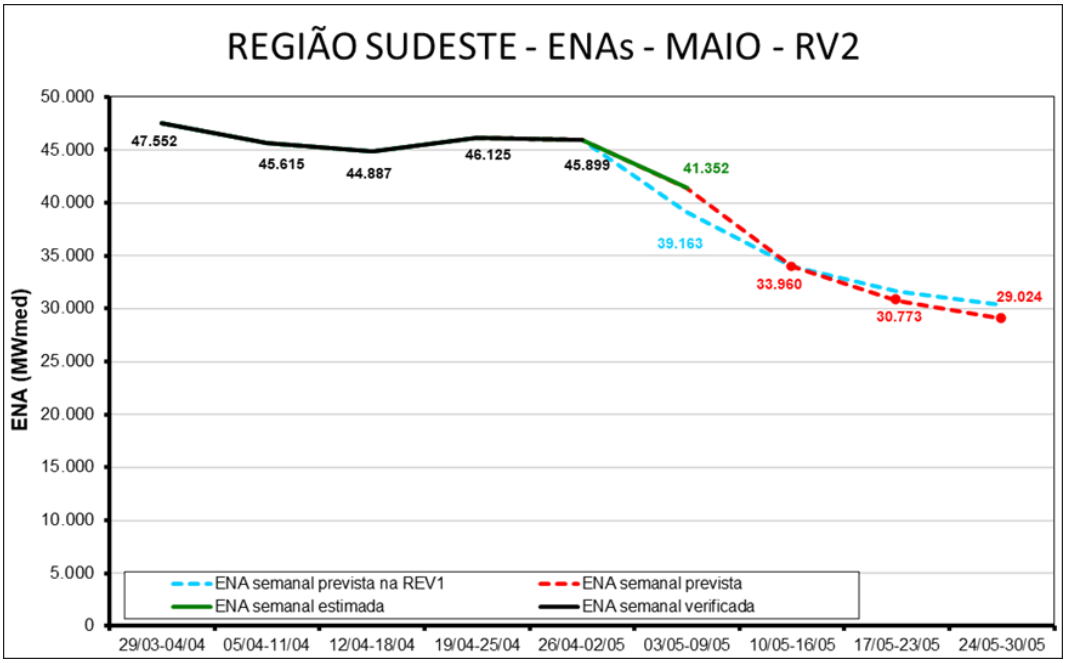

Figura 4 - Energias Naturais Afluentes ao Subsistema Sul das Revisões 1 e 2 do PMO de Maio/2025

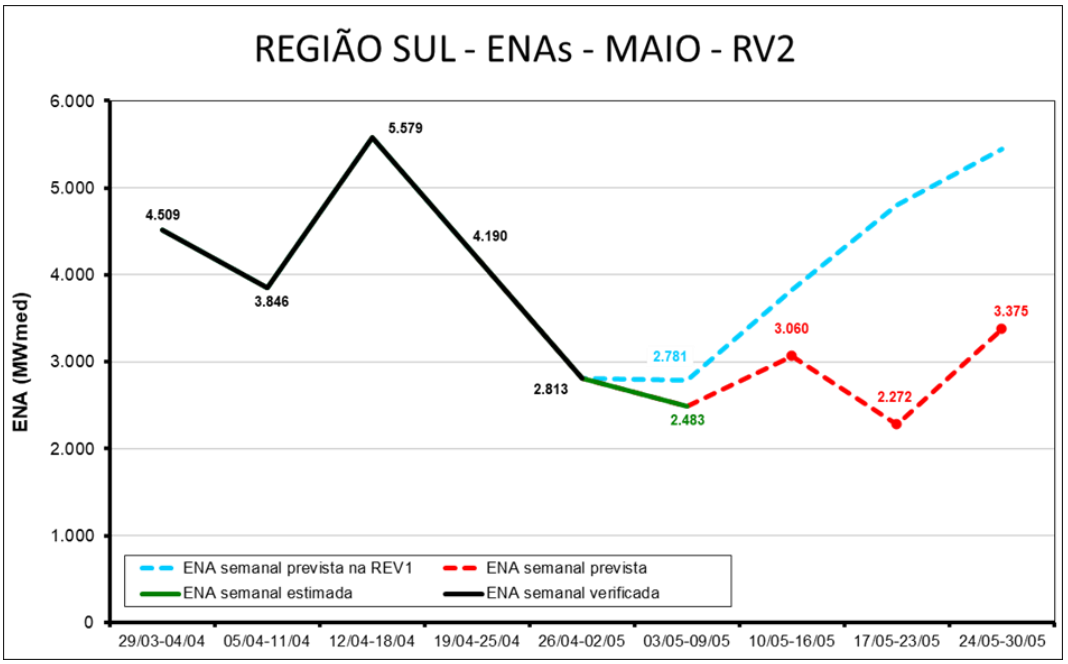

O conteúdo desta publicação foi produzido pelo ONS com base em dados e informações de conhecimento público. É de responsabilidade exclusiva dos agentes e demais interessados a obtenção de outros dados e informações, a realização de análises, estudos e avaliações para fins de tomada de decisões, definição de estratégias de atuação, assunção de compromissos e obrigações e quaisquer outras finalidades, em qualquer tempo e sob qualquer condição. É proibida a reprodução ou utilização total ou parcial do presente sem a identificação da fonte.

Figura 5 - Energias Naturais Afluentes ao Subsistema Nordeste das Revisões 1 e 2 do PMO de Maio/2025

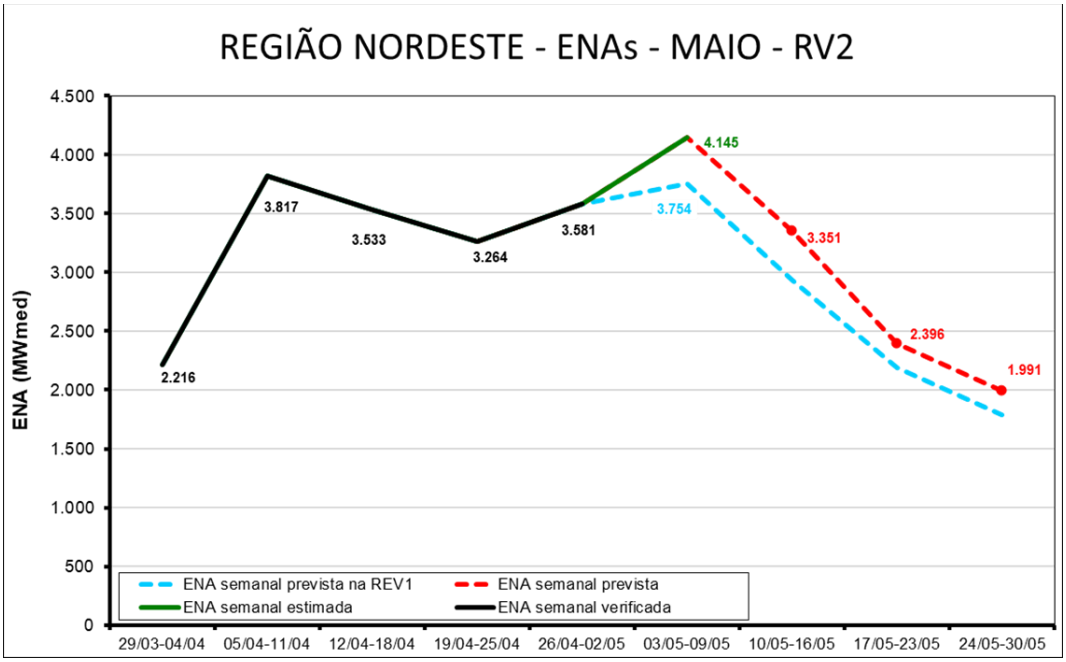

Figura 6 - Energias Naturais Afluentes ao Subsistema Norte das Revisões 1 e 2 do PMO de Maio/2025

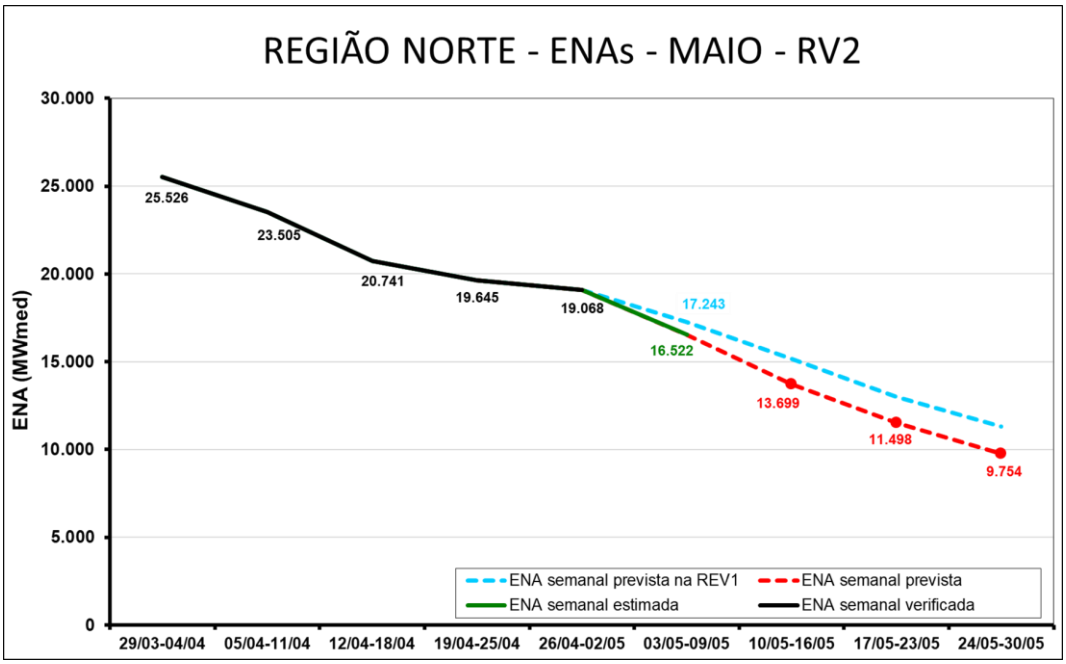

O conteúdo desta publicação foi produzido pelo ONS com base em dados e informações de conhecimento público. É de responsabilidade exclusiva dos agentes e demais interessados a obtenção de outros dados e informações, a realização de análises, estudos e avaliações para fins de tomada de decisões, definição de estratégias de atuação, assunção de compromissos e obrigações e quaisquer outras finalidades, em qualquer tempo e sob qualquer condição. É proibida a reprodução ou utilização total ou parcial do presente sem a identificação da fonte.

3.1.3. Cenários de ENAs para a Revisão 2 de maio/2025

As figuras a seguir apresentam as características dos cenários de energias naturais afluentes gerados na Revisão 2 de Maio/2025, para acoplamento com a FCF do mês de junho/2025. São mostradas, para os quatro subsistemas, as amplitudes e as Funções de Distribuição Acumulada dos cenários de ENA, comparativamente com os valores considerados para as revisões anteriores do PMO de Maio/2025.

Figura 7 - Amplitude dos Cenários de ENA para o Subsistema Sudeste/Centro-Oeste, em %MLT, para a Revisão 2 de Maio/2025

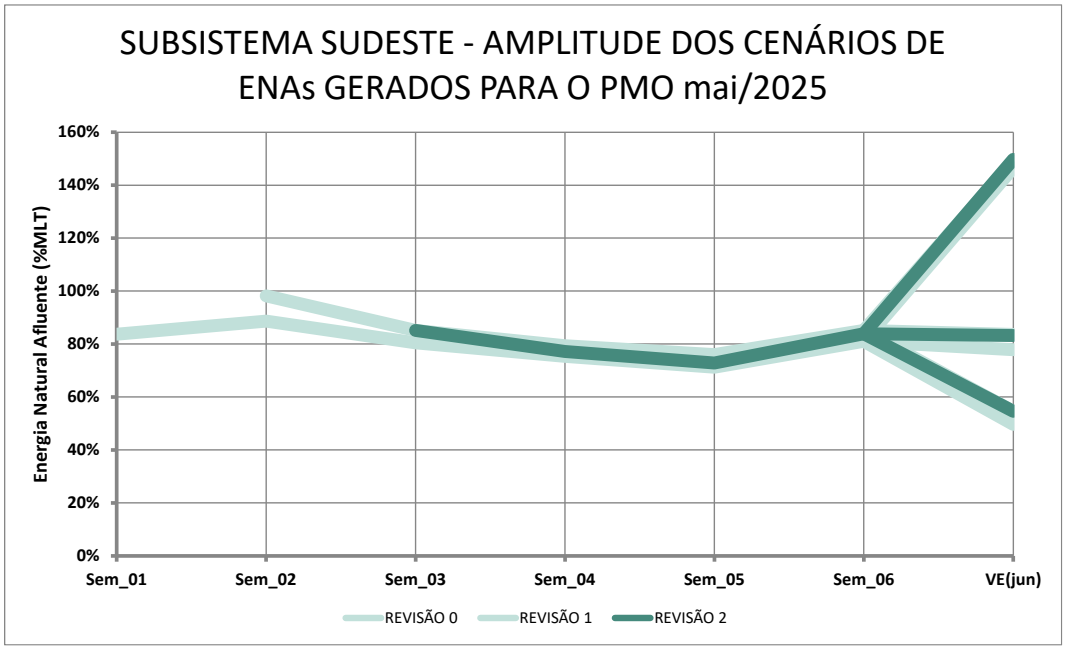

Figura 8 - Função de Distribuição Acumulada dos Cenários para o Subsistema Sudeste/Centro-Oeste para a Revisão 2 de Maio/2025

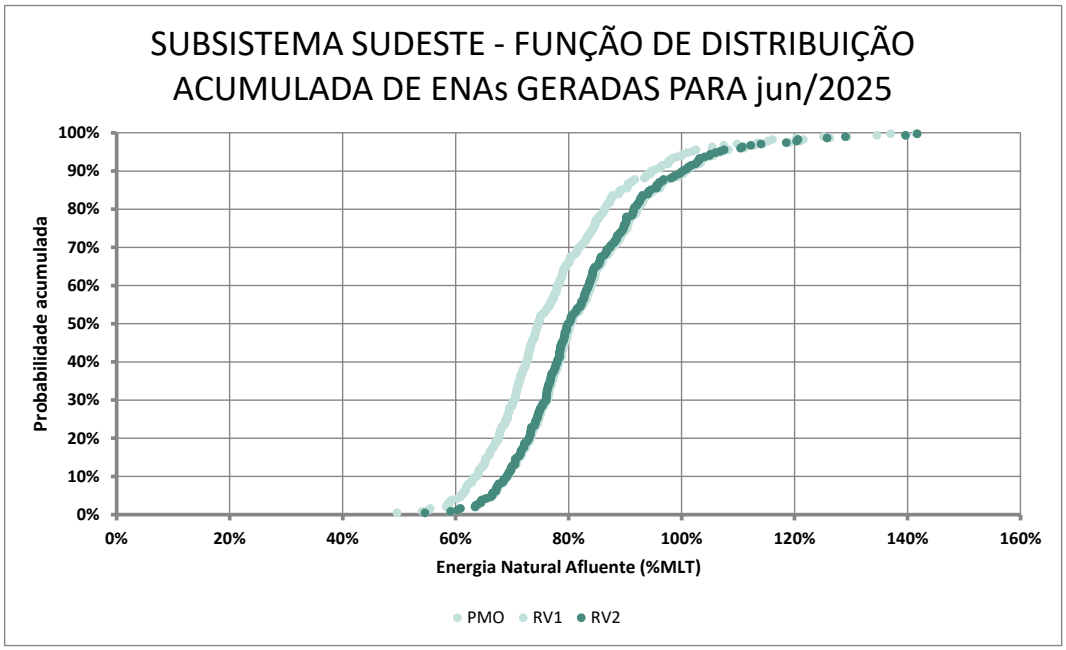

O conteúdo desta publicação foi produzido pelo ONS com base em dados e informações de conhecimento público. É de responsabilidade exclusiva dos agentes e demais interessados a obtenção de outros dados e informações, a realização de análises, estudos e avaliações para fins de tomada de decisões, definição de estratégias de atuação, assunção de compromissos e obrigações e quaisquer outras finalidades, em qualquer tempo e sob qualquer condição. É proibida a reprodução ou utilização total ou parcial do presente sem a identificação da fonte.

Figura 9 - Amplitude dos Cenários de ENA para o Subsistema Sul, em %MLT, para a Revisão 2 de Maio/2025

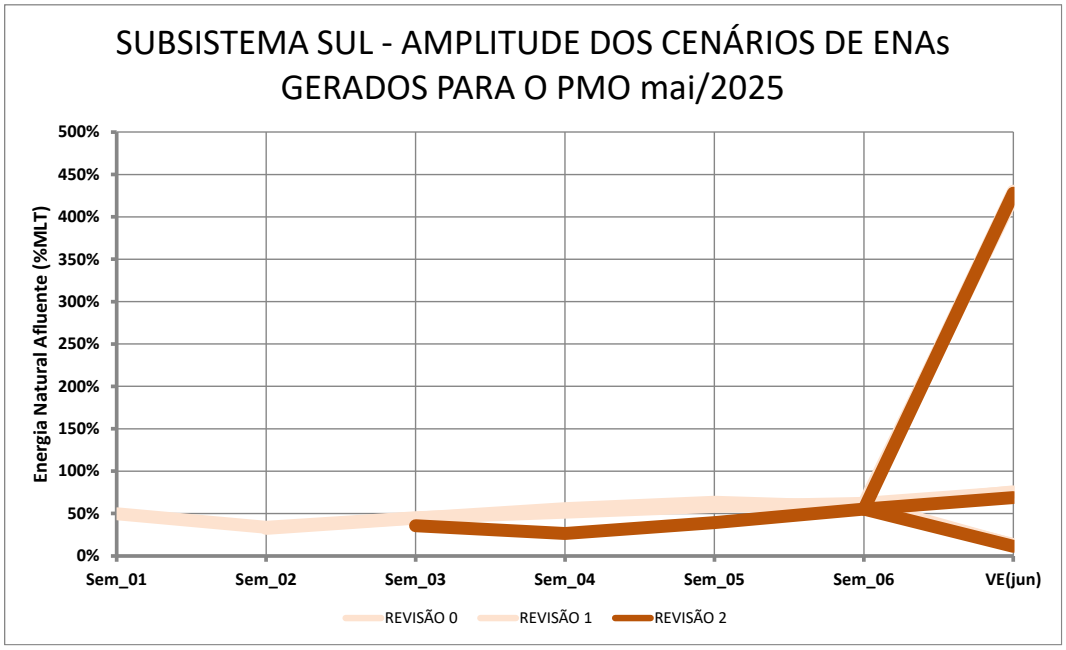

Figura 10 - Função de Distribuição Acumulada dos Cenários para o Subsistema Sul para a Revisão 2 de Maio/2025

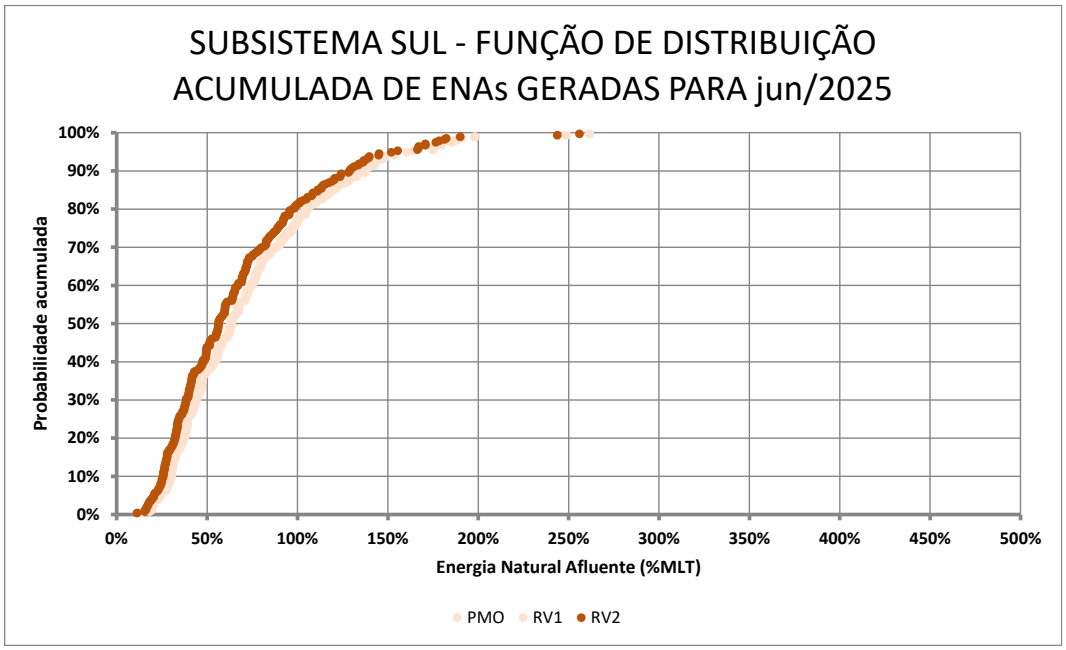

O conteúdo desta publicação foi produzido pelo ONS com base em dados e informações de conhecimento público. É de responsabilidade exclusiva dos agentes e demais interessados a obtenção de outros dados e informações, a realização de análises, estudos e avaliações para fins de tomada de decisões, definição de estratégias de atuação, assunção de compromissos e obrigações e quaisquer outras finalidades, em qualquer tempo e sob qualquer condição. É proibida a reprodução ou utilização total ou parcial do presente sem a identificação da fonte.

Figura 11 - Amplitude dos Cenários de ENA para o Subsistema Nordeste em %MLT, para a Revisão 2 de Maio/2025

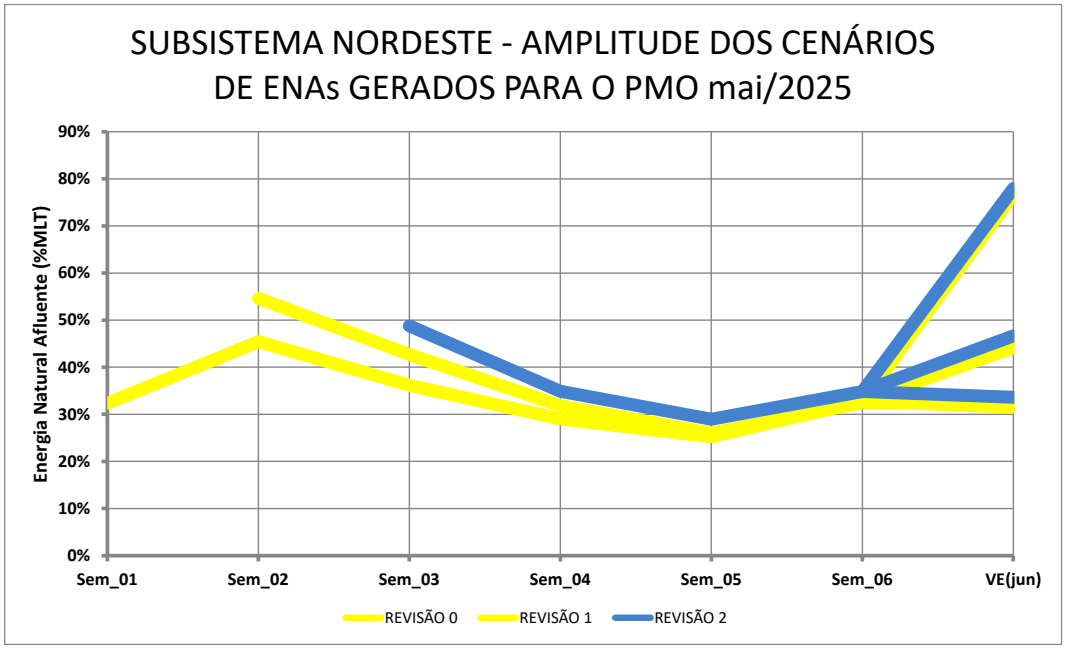

Figura 12 - Função de Distribuição Acumulada dos Cenários para o Subsistema Nordeste para a Revisão 2 de Maio/2025

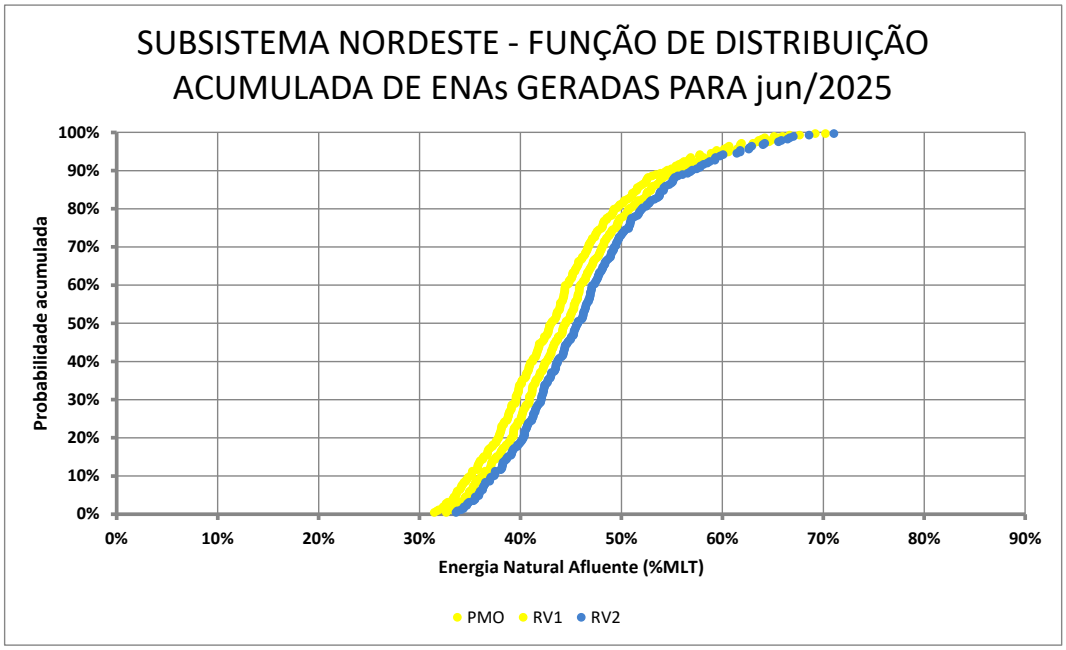

O conteúdo desta publicação foi produzido pelo ONS com base em dados e informações de conhecimento público. É de responsabilidade exclusiva dos agentes e demais interessados a obtenção de outros dados e informações, a realização de análises, estudos e avaliações para fins de tomada de decisões, definição de estratégias de atuação, assunção de compromissos e obrigações e quaisquer outras finalidades, em qualquer tempo e sob qualquer condição. É proibida a reprodução ou utilização total ou parcial do presente sem a identificação da fonte.

Figura 13 - Amplitude dos Cenários de ENA para o Subsistema Norte, em %MLT, para a Revisão 2 de Maio/2025

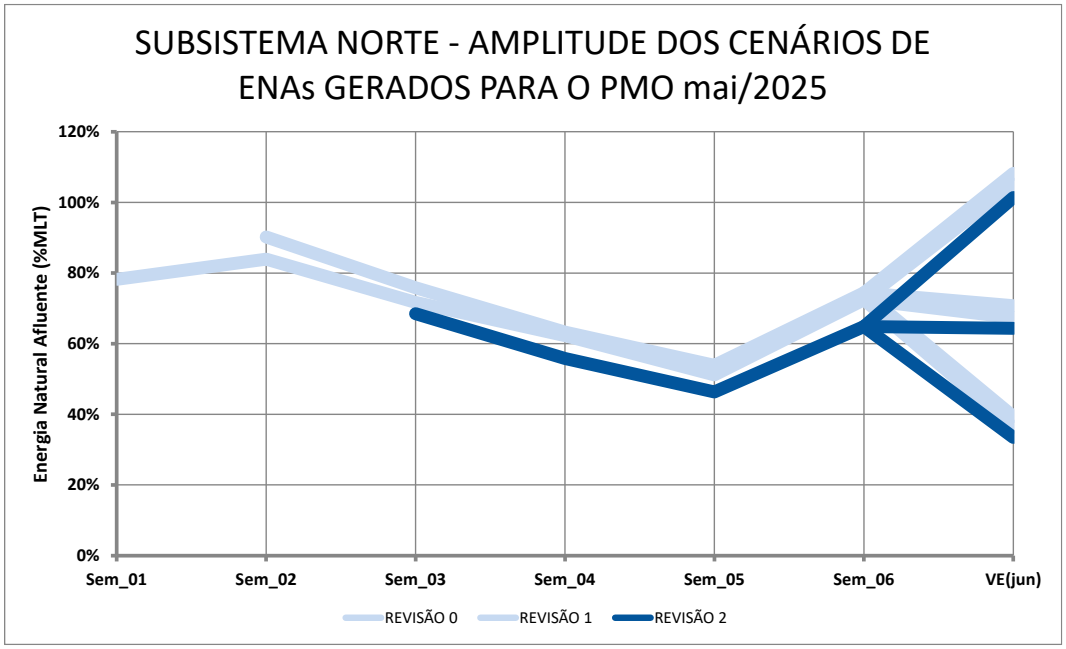

Figura 14 - Função de Distribuição Acumulada dos Cenários para o Subsistema Norte para a Revisão 2 de Maio/2025

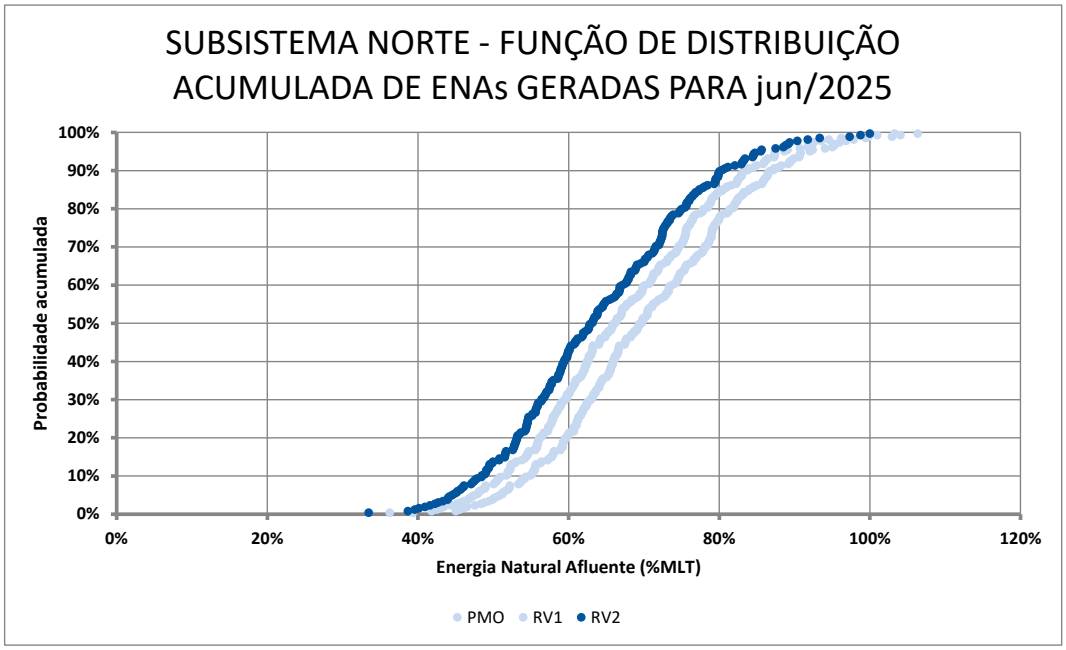

O conteúdo desta publicação foi produzido pelo ONS com base em dados e informações de conhecimento público. É de responsabilidade exclusiva dos agentes e demais interessados a obtenção de outros dados e informações, a realização de análises, estudos e avaliações para fins de tomada de decisões, definição de estratégias de atuação, assunção de compromissos e obrigações e quaisquer outras finalidades, em qualquer tempo e sob qualquer condição. É proibida a reprodução ou utilização total ou parcial do presente sem a identificação da fonte.

Os valores da MLT (Média de Longo Termo) das energias naturais afluentes para os meses de maio/2025 e junho/2025 são apresentados na tabela a seguir.

Tabela 3 – MLT da ENA nos meses de maio/2025 e junho/2025

MLT das ENAs (MWmed)		
Subsistema	maio	junho
SE/CO	39.863	32.541
S	8.594	10.573
NE	6.871	4.535
N	20.476	10.669

3.2. Limites de Intercâmbio entre Subsistemas

Os limites elétricos de intercâmbio de energia entre subsistemas são de fundamental importância para o processo de otimização energética, sendo determinantes para a definição das políticas de operação e do CMO para cada subsistema. Estes limites são influenciados por intervenções na malha de transmissão, notadamente na primeira semana operativa. O diagrama a seguir ilustra os fluxos notáveis do SIN e os limites aplicados neste PMO.

Figura 15 – Interligações entre regiões

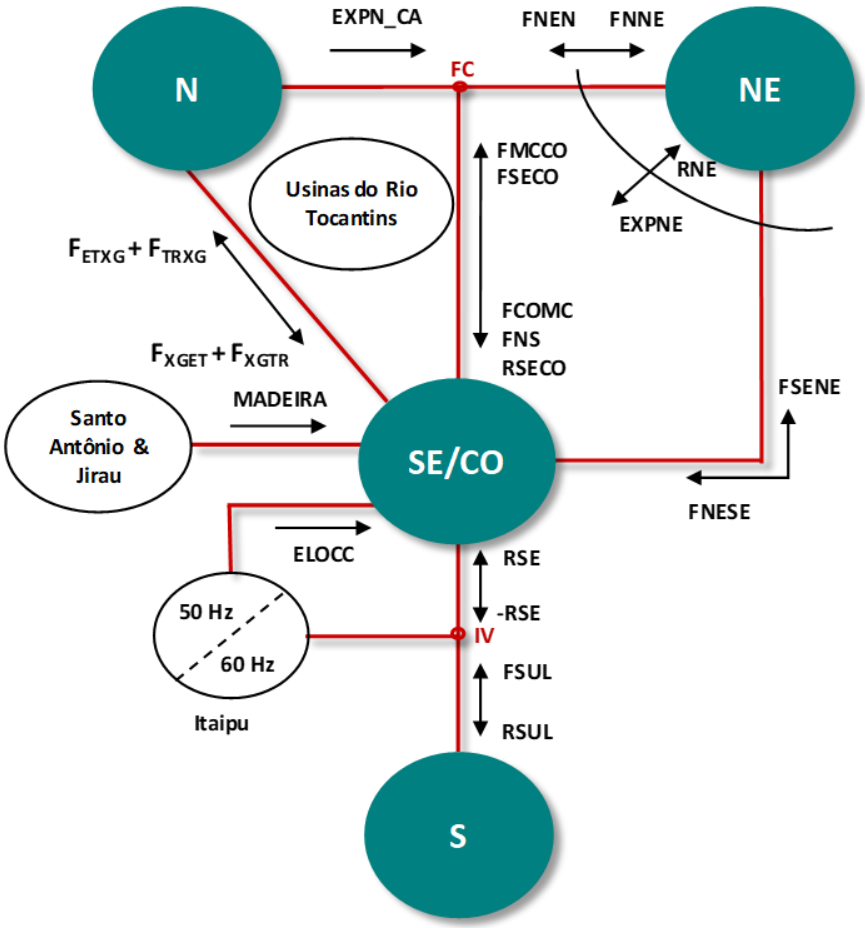

O conteúdo desta publicação foi produzido pelo ONS com base em dados e informações de conhecimento público. É de responsabilidade exclusiva dos agentes e demais interessados a obtenção de outros dados e informações, a realização de análises, estudos e avaliações para fins de tomada de decisões, definição de estratégias de atuação, assunção de compromissos e obrigações e quaisquer outras finalidades, em qualquer tempo e sob qualquer condição. É proibida a reprodução ou utilização total ou parcial do presente sem a identificação da fonte.

Tabela 4 – Limites considerados nesta semana operativa para intercâmbio de energia

Limites de Intercâmbio (MWmed)				
Fluxo	Patamar	10/05 a 16/05/2025		Demais Semanas
RNE	Pesada	11.000		11.000
	Média	11.000		11.000
	Leve	11.000		11.000
FNS	Pesada	3.200		3.200
	Média	3.200		3.200
	Leve	3.000		3.000
FNNE	Pesada	**7.340**		7.800
	Média	**7.092**	(A)	7.800
	Leve	**7.535**		7.800
EXPORT. NE	Pesada	13.800		13.800
	Média	13.800		13.800
	Leve	13.800		13.800
FMCCO	Pesada	5.000		5.000
	Média	5.000		5.000
	Leve	5.000		5.000
FSENE	Pesada	6.000		6.000
	Média	6.000		6.000
	Leve	6.000		6.000
FNS + FNESE	Pesada	7.366		7.366
	Média	6.031		6.031
	Leve	7.300		7.300
RSE	Pesada	6.770		6.770
	Média	**8.685**	(B)	9.070
	Leve	**8.888**		10.330
FORNEC. SUL	Pesada	7.000		7.000
	Média	7.000		7.000
	Leve	8.600		8.600

Limites de Intercâmbio (MWmed)				
Fluxo	Patamar	10/05 a 16/05/2025		Demais Semanas
RECEB. SUL	Pesada	7.900		7.900
	Média	**4.873**	(B)	4.950
	Leve	**8.312**		8.600
ELO CC 50 Hz	Pesada	**5.481**		6.264
	Média	**5.481**	(C) (D)	6.264
	Leve	**5.481**		6.264
ITAIPU 60 Hz	Pesada	**7.040**		7.500
	Média	**6.231**	(E) (F)	7.500
	Leve	**5.888**		7.500
EXP. N CA	Pesada	8.000		8.000
	Média	8.000		8.000
	Leve	8.000		8.000
FETXG + FTRXG	Pesada	4.200		4.200
	Média	4.200		4.200
	Leve	4.200		4.200
FXGET + FXGTR	Pesada	8.000		8.000
	Média	8.000		8.000
	Leve	8.000		8.000
FNESE	Pesada	5.600		5.600
	Média	**4.482**	(G) (H) (I)	4.494
	Leve	**5.569**		5.600
FNEN	Pesada	**5.580**		5.600
	Média	**5.569**	(A)	5.600
	Leve	**5.588**		5.600
Ger_MADEIRA	Pesada	7.418		7.418
	Média	7.402	(J)	7.402
	Leve	**6.478**		7.367

(A) SGI 25.542-25
(B) SGI 10.911-25
(C) SGI 20.392-25
(D) SGI 20.466-25
(E) SGI 26.511-25
(F) SGI 27.642-25
(G) SGI 28.254-25
(H) SGI 28.256-25
(I) SGI 28.257-25
(J) SGI 23.136-25

O conteúdo desta publicação foi produzido pelo ONS com base em dados e informações de conhecimento público. É de responsabilidade exclusiva dos agentes e demais interessados a obtenção de outros dados e informações, a realização de análises, estudos e avaliações para fins de tomada de decisões, definição de estratégias de atuação, assunção de compromissos e obrigações e quaisquer outras finalidades, em qualquer tempo e sob qualquer condição. É proibida a reprodução ou utilização total ou parcial do presente sem a identificação da fonte.

3.3. Previsão de carga

A partir do fechamento dos valores da Revisão 2 do PMO de Maio, as projeções de carga indicam variações de -3,4% no Subsistema Sudeste/Centro-Oeste, 2,8% no Subsistema Sul, 3,2% no Subsistema Nordeste e 6,9% no Subsistema Norte, em relação ao mesmo mês do ano anterior. Os principais fatores para essas variações estão descritos a seguir.

A estimativa de fechamento da carga global de energia na semana operativa atual (03/05 a 09/05) aponta, no Sistema Interligado Nacional (SIN), resultado 0,6% superior ao da semana anterior (26/04 a 02/05), consolidando uma expectativa de 78.094 MW médios.

Na análise por Subsistemas, o Sudeste/Centro-Oeste apresentou declínio de 0,3% em relação à semana operativa anterior, correspondendo a um comportamento inesperado na carga global verificada, visto que houve a transição de uma semana com feriado na quinta-feira (01/05) para uma semana sem feriados. Além disso, a ocorrência de temperaturas inferiores as esperadas no Rio de Janeiro contribuíram para o desvio de 7,6% nas previsões. No Subsistema Sul, houve maior assertividade nas previsões com desvio de 0,6%, resultado considerado relevante dada a alta variabilidade de temperatura nas regiões que compõem a área. Com relação à semana anterior, a carga apresentou crescimento de 4,0%, evidenciando uma trajetória ascendente.

Os Subsistemas Nordeste e Norte apresentaram desvios de 2,0% e 1,0%, respectivamente, com expectativas de fechamento de 13.575 MW médios e 8.242 MW médios. No caso do Nordeste, a variação de carga de -0,9% frente à primeira semana operativa decorre da ocorrência de chuvas intensas em Salvador. No Norte, o incremento de carga observada na segunda semana motivou ajustes nas demais semanas, de forma a manter a carga estimada alinhada com o nível recentemente verificado.

Para a próxima semana operativa (10/05 a 16/05), projeta-se um decréscimo de 0,4% na carga do SIN, influenciado principalmente pelas menores temperaturas nas regiões Sudeste e Sul. No Sudeste, há previsão de queda nas temperaturas no Rio de Janeiro, São Paulo e Espírito Santo, impactando diretamente a carga do Subsistema. No Sul, o declínio das temperaturas em Porto Alegre e Curitiba também contribuiu para ajustes negativos na previsão de carga. O Subsistema Nordeste não apresentou mudanças significativas nas premissas meteorológicas, o que resultou na manutenção das projeções para as próximas semanas. Por fim, diante do crescimento observado na carga do Norte, foram realizados ajustes em todas as semanas seguintes, visando manter os valores projetados compatíveis com a tendência de elevação recente.

Tabela 5 – Evolução da carga do PMO de Maio de 2025

Subsistema	CARGA SEMANAL (MWmed)						CARGA MENSAL (MWmed)	
	1ª Sem	2ª Sem	3ª Sem	4ª Sem	5ª Sem	6ª Sem	mai/25	Var. (%) mai/25 -> mai/24
SE/CO	43.047	42.965	42.827	44.687	44.779	44.706	43.794	-3,4%
Sul	12.846	13.313	13.320	13.351	13.406	13.433	13.318	2,8%
Nordeste	13.702	13.575	13.530	13.350	13.319	13.119	13.450	3,2%
Norte	8.044	8.242	8.127	8.245	8.233	8.188	8.200	6,9%
SIN	**77.639**	**78.095**	**77.804**	**79.633**	**79.737**	**79.446**	**78.762**	**-0,3%**

O conteúdo desta publicação foi produzido pelo ONS com base em dados e informações de conhecimento público. É de responsabilidade exclusiva dos agentes e demais interessados a obtenção de outros dados e informações, a realização de análises, estudos e avaliações para fins de tomada de decisões, definição de estratégias de atuação, assunção de compromissos e obrigações e quaisquer outras finalidades, em qualquer tempo e sob qualquer condição. É proibida a reprodução ou utilização total ou parcial do presente sem a identificação da fonte.

3.4. Potência Hidráulica Total Disponível no SIN

O gráfico a seguir mostra a disponibilidade hidráulica total do SIN, para este mês, de acordo com o cronograma de manutenção informado pelos agentes para esta revisão.

Figura 16 – Potência hidráulica disponível no SIN

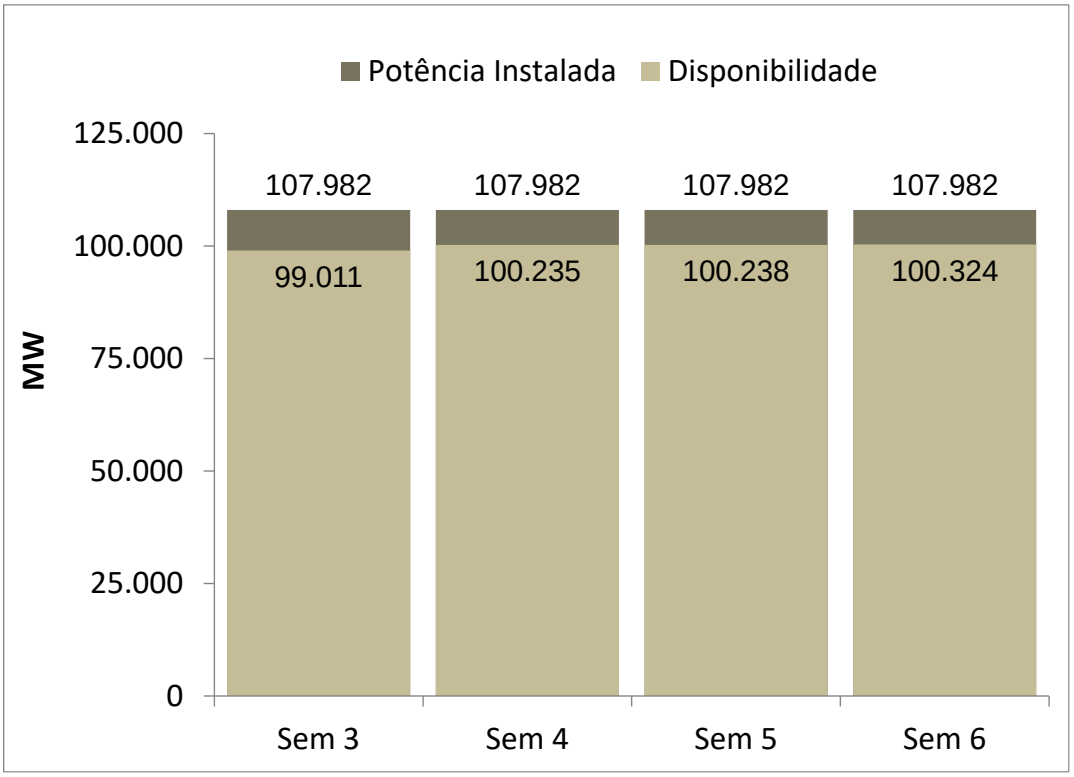

3.5. Armazenamentos Iniciais por Subsistema

Tabela 6 – Armazenamentos iniciais, por subsistema, considerados para esta semana operativa

Armazenamento (%EARmáx) - 0:00 h do dia 10/05/2025		
Subsistema	**Nível previsto na Revisão 1 do PMO Mai/2025**	**Partida informada pelos Agentes para a Revisão 2 do PMO Mai/2025**
SE/CO	71,0	70,2
S	38,8	37,5
NE	76,3	76,2
N	97,5	97,6

A primeira coluna da tabela acima corresponde ao armazenamento previsto na Revisão 1 do PMO de Maio de 2025, para a 0:00 h do dia 10/05/2025. A segunda coluna apresenta os armazenamentos obtidos a partir dos níveis de partida informados pelos Agentes de Geração para seus aproveitamentos com reservatórios.

O conteúdo desta publicação foi produzido pelo ONS com base em dados e informações de conhecimento público. É de responsabilidade exclusiva dos agentes e demais interessados a obtenção de outros dados e informações, a realização de análises, estudos e avaliações para fins de tomada de decisões, definição de estratégias de atuação, assunção de compromissos e obrigações e quaisquer outras finalidades, em qualquer tempo e sob qualquer condição. É proibida a reprodução ou utilização total ou parcial do presente sem a identificação da fonte.

4. PRINCIPAIS RESULTADOS

4.1. Política de Operação Energética

Para esta semana operativa, está prevista a seguinte política de intercâmbio de energia entre regiões:

Região SE/CO:

- Utilização dos recursos das bacias dos rios Grande e Paranaíba, e possibilidade de elevação das defluências das usinas do rio Paraná, conforme necessidade de alocação na carga, manutenção dos limites da interligação Sul/Sudeste, e controle de nível dos reservatórios. Exploração dos recursos energéticos nas usinas das bacias dos rios Madeira e Teles Pires.

Região Sul:

- Operação minimizada buscando redução de deplecionamento e controle do nível dos reservatórios, modulando geração hidráulica para atendimento à carga e controle de fluxos elétricos, principalmente RSUL e FBTA.

Região NE:

- Operação minimizada na cascata do Rio São Francisco devido aos limites de interligação. Defluência mínima média diária na UHE Xingó de 1.100 m³/s, em atendimento à resolução da ANA 2081 – 2017.

Região Norte:

- Exploração das usinas das bacias do rio Tocantins e do rio Xingu, respeitando-se as restrições operativas e os limites elétricos vigentes. Operação para controle de nível na UHE Balbina.

4.2. Custo Marginal de Operação – CMO

A figura a seguir apresenta os Custos Marginais de Operação, em valores médios semanais, para as semanas operativas deste mês.

Figura 17 – CMO em valores médios

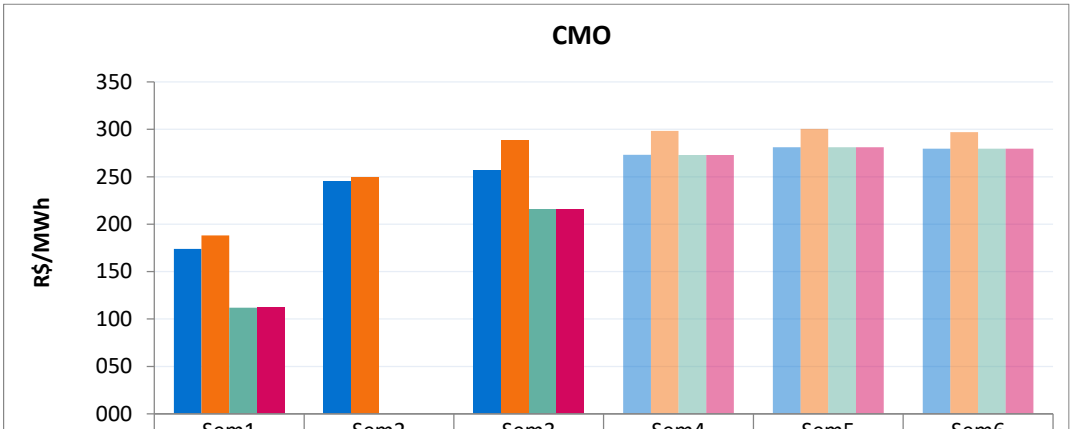

	Sem1	Sem2	Sem3	Sem4	Sem5	Sem6
Sudeste	173,87	244,95	256,93	273,23	281,20	279,67
Sul	188,15	249,34	288,94	298,42	300,47	297,14
Nordeste	111,94	0,00	216,13	272,87	281,20	279,67
Norte	111,94	0,00	216,13	272,87	281,20	279,67

A tabela a seguir apresenta o custo marginal de operação, por subsistema e patamar de carga, para a próxima semana operativa.

O conteúdo desta publicação foi produzido pelo ONS com base em dados e informações de conhecimento público. É de responsabilidade exclusiva dos agentes e demais interessados a obtenção de outros dados e informações, a realização de análises, estudos e avaliações para fins de tomada de decisões, definição de estratégias de atuação, assunção de compromissos e obrigações e quaisquer outras finalidades, em qualquer tempo e sob qualquer condição. É proibida a reprodução ou utilização total ou parcial do presente sem a identificação da fonte.

Tabela 7 – CMO para esta semana operativa

Patamares de Carga	CMO (R$/MWh)			
	SE/CO	S	NE	N
Pesada	273,36	322,15	219,32	219,32
Média	258,36	322,31	215,57	215,57
Leve	250,48	250,48	215,57	215,57
Média Semanal	256,93	288,94	216,13	216,13

4.3. Energia Armazenada

O processo de otimização realizado pelo programa DECOMP indicou os armazenamentos mostrados na figura a seguir para as próximas semanas operativas do mês de maio/2025.

Figura 18 – Energias Armazenadas nas semanas operativas do mês de maio/2025

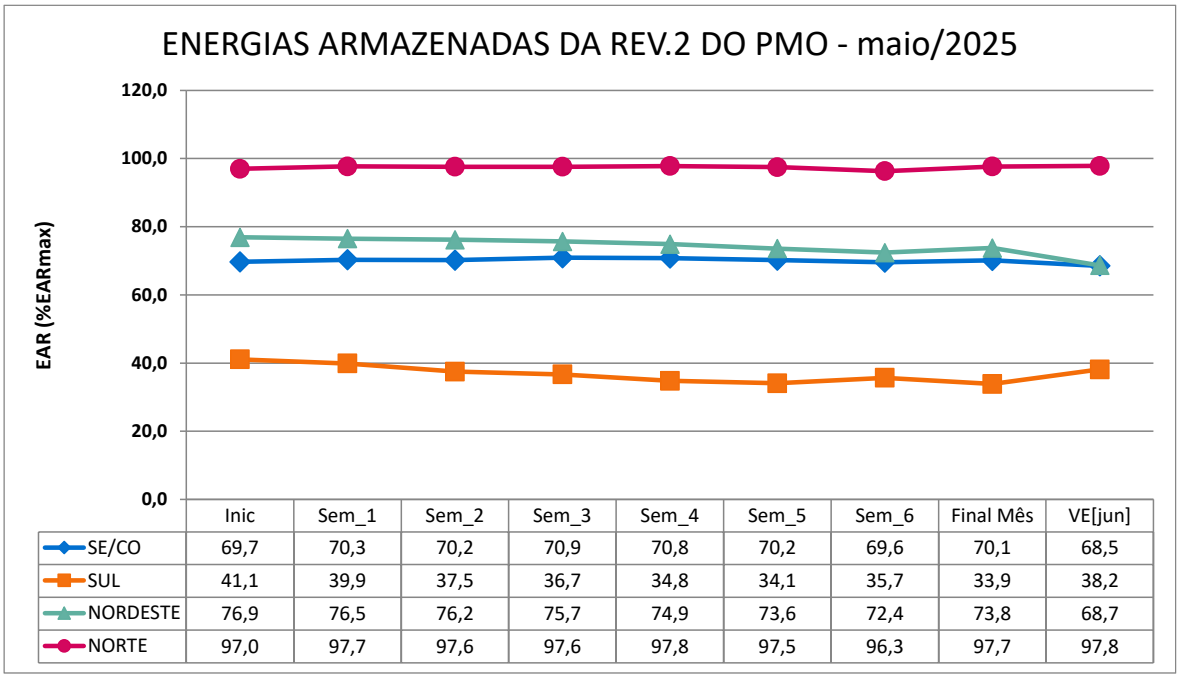

	Inic	Sem_1	Sem_2	Sem_3	Sem_4	Sem_5	Sem_6	Final Mês	VE[jun]
SE/CO	69,7	70,3	70,2	70,9	70,8	70,2	69,6	70,1	68,5
SUL	41,1	39,9	37,5	36,7	34,8	34,1	35,7	33,9	38,2
NORDESTE	76,9	76,5	76,2	75,7	74,9	73,6	72,4	73,8	68,7
NORTE	97,0	97,7	97,6	97,6	97,8	97,5	96,3	97,7	97,8

Os armazenamentos da figura anterior estão expressos em percentual da Energia Armazenável Máxima de cada subsistema, que são mostradas na tabela a seguir.

Tabela 8 – Energia Armazenável Máxima por subsistema no PMO de Maio/2025.

ENERGIA ARMAZENÁVEL MÁXIMA (MWmed)		
Subsistema	maio	junho
SE/CO	205.582	205.582
S	20.458	20.458
NE	51.718	51.718
N	14.163	14.795

O conteúdo desta publicação foi produzido pelo ONS com base em dados e informações de conhecimento público. É de responsabilidade exclusiva dos agentes e demais interessados a obtenção de outros dados e informações, a realização de análises, estudos e avaliações para fins de tomada de decisões, definição de estratégias de atuação, assunção de compromissos e obrigações e quaisquer outras finalidades, em qualquer tempo e sob qualquer condição. É proibida a reprodução ou utilização total ou parcial do presente sem a identificação da fonte.

5. GERAÇÃO TÉRMICA

A Figura 19 apresenta, para cada subsistema do SIN, o despacho térmico por modalidade indicado pelo Decomp para esta semana operativa.

Figura 19 – Geração térmica para a próxima semana operativa

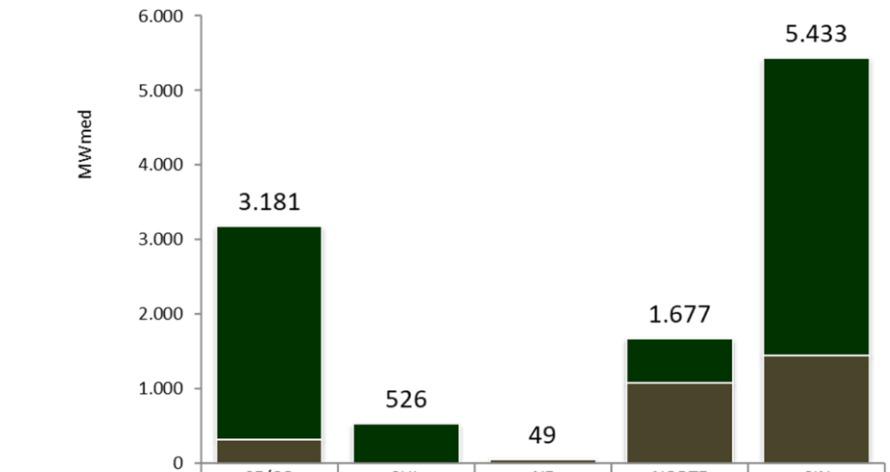

	SE/CO	SUL	NE	NORTE	SIN
TOTAL	3.181	526	49	1.677	5.433
RESTRIÇÃO ELÉTRICA	0	0	0	0	0
INFLEXIBILIDADE	2866	522	4	597	3989
ORDEM DE MÉRITO	315	4	45	1080	1444

Na tabela abaixo segue a Indicação de despacho antecipado por ordem de mérito de custo para a semana de 12/07/2025 a 18/07/2025.

Tabela 9 – UTEs com contrato de combustível GNL

UTE			Benefício (R$/MWh)			Despacho antecipado por mérito		
Nome	Código	CVU (R$/MWh)	Carga Pesada	Carga Média	Carga Leve	Carga Pesada	Carga Média	Carga Leve
SANTA CRUZ	86	232,91	274,03	266,22	262,62	Sim	Sim	Sim
LUIZORMELO	15	352,56	274,03	266,22	262,62	Não	Não	Não
PSERGIPE I	224	335,41	269,09	265,07	262,56	Não	Não	Não

Assim sendo, há indicação de despacho antecipado por ordem de mérito de custo para a UTE Santa Cruz para a semana de 12/07/2025 a 18/07/2025 nos três patamares de carga.

Para as UTEs Luiz O. R. Melo e Porto Sergipe I, não há indicação de despacho antecipado.

O conteúdo desta publicação foi produzido pelo ONS com base em dados e informações de conhecimento público. É de responsabilidade exclusiva dos agentes e demais interessados a obtenção de outros dados e informações, a realização de análises, estudos e avaliações para fins de tomada de decisões, definição de estratégias de atuação, assunção de compromissos e obrigações e quaisquer outras finalidades, em qualquer tempo e sob qualquer condição. É proibida a reprodução ou utilização total ou parcial do presente sem a identificação da fonte.

6. RESUMO DOS RESULTADOS DO PMO

As figuras a seguir apresentam um resumo dos resultados da Revisão 2 de Maio/2025, com informações da Energia Natural Afluente (ENA), da Energia Armazenada (EAR) e do Custo Marginal de Operação (CMO) nos subsistemas do Sistema Interligado Nacional (SIN). São apresentados os valores semanais observados e previstos e o valor esperado dos cenários gerados para o mês de junho/2025.

Figura 20 – Resumo de maio/2025 para o Subsistema Sudeste/Centro-Oeste

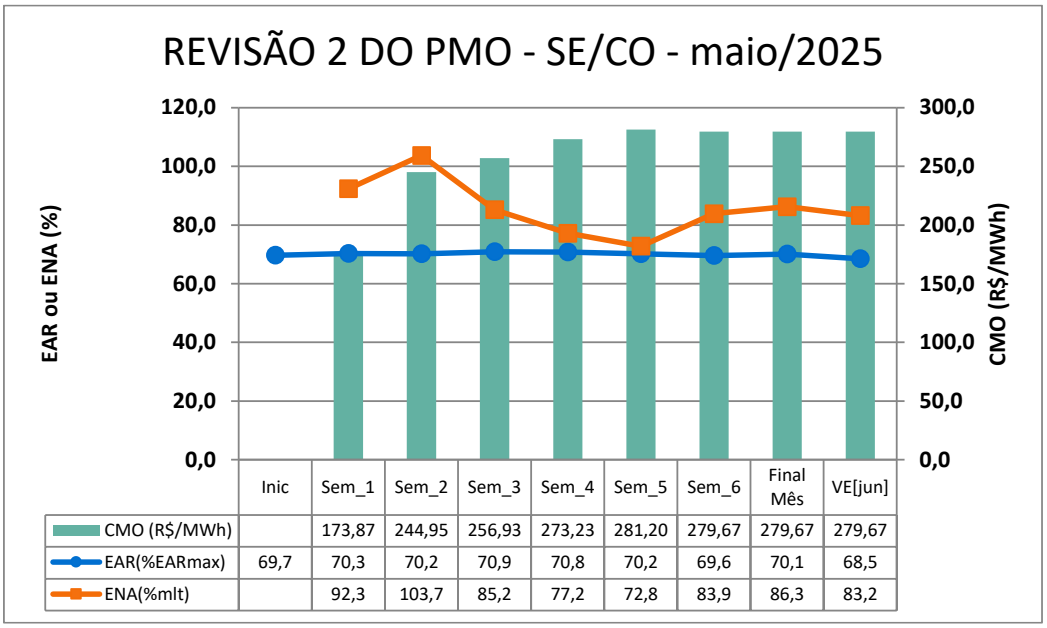

	Inic	Sem_1	Sem_2	Sem_3	Sem_4	Sem_5	Sem_6	Final Mês	VE[jun]
CMO (R$/MWh)		173,87	244,95	256,93	273,23	281,20	279,67	279,67	279,67
EAR(%EARmax)	69,7	70,3	70,2	70,9	70,8	70,2	69,6	70,1	68,5
ENA(%mlt)		92,3	103,7	85,2	77,2	72,8	83,9	86,3	83,2

Figura 21 – Resumo de maio/2025 para o Subsistema Sul

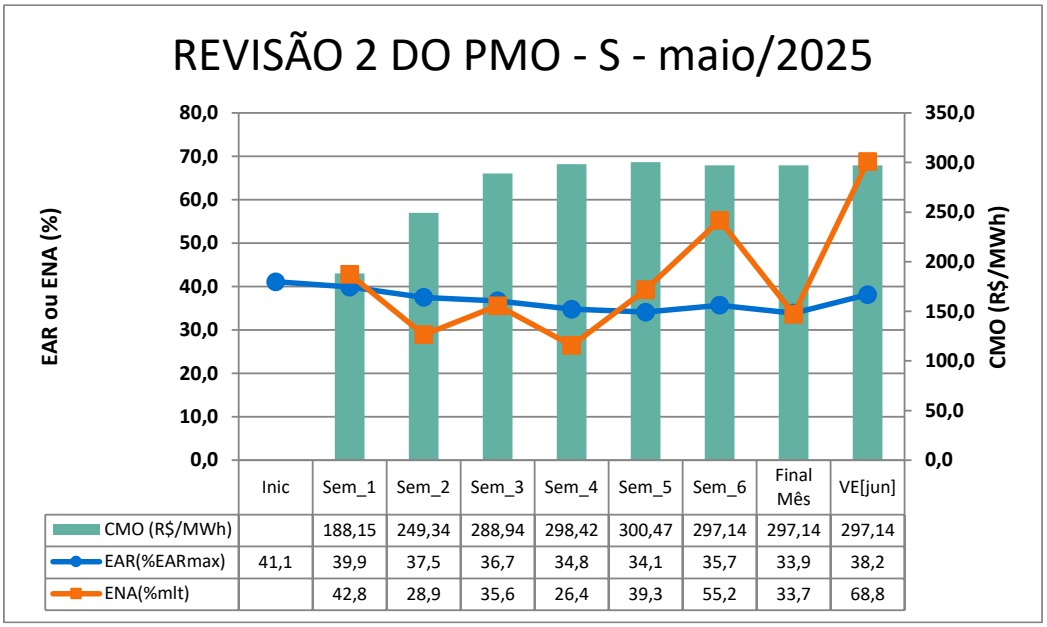

	Inic	Sem_1	Sem_2	Sem_3	Sem_4	Sem_5	Sem_6	Final Mês	VE[jun]
CMO (R$/MWh)		188,15	249,34	288,94	298,42	300,47	297,14	297,14	297,14
EAR(%EARmax)	41,1	39,9	37,5	36,7	34,8	34,1	35,7	33,9	38,2
ENA(%mlt)		42,8	28,9	35,6	26,4	39,3	55,2	33,7	68,8

O conteúdo desta publicação foi produzido pelo ONS com base em dados e informações de conhecimento público. É de responsabilidade exclusiva dos agentes e demais interessados a obtenção de outros dados e informações, a realização de análises, estudos e avaliações para fins de tomada de decisões, definição de estratégias de atuação, assunção de compromissos e obrigações e quaisquer outras finalidades, em qualquer tempo e sob qualquer condição. É proibida a reprodução ou utilização total ou parcial do presente sem a identificação da fonte.

Figura 22 – Resumo de maio/2025 para o Subsistema Nordeste

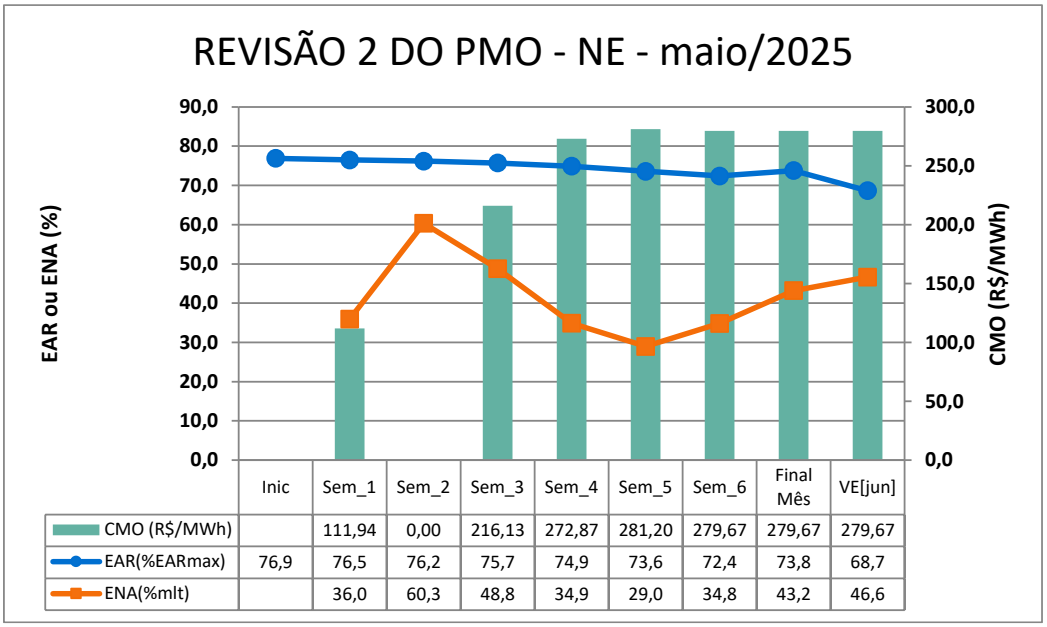

	Inic	Sem_1	Sem_2	Sem_3	Sem_4	Sem_5	Sem_6	Final Mês	VE[jun]
CMO (R$/MWh)		111,94	0,00	216,13	272,87	281,20	279,67	279,67	279,67
EAR(%EARmax)	76,9	76,5	76,2	75,7	74,9	73,6	72,4	73,8	68,7
ENA(%mlt)		36,0	60,3	48,8	34,9	29,0	34,8	43,2	46,6

Figura 23 – Resumo de maio/2025 para o Subsistema Norte

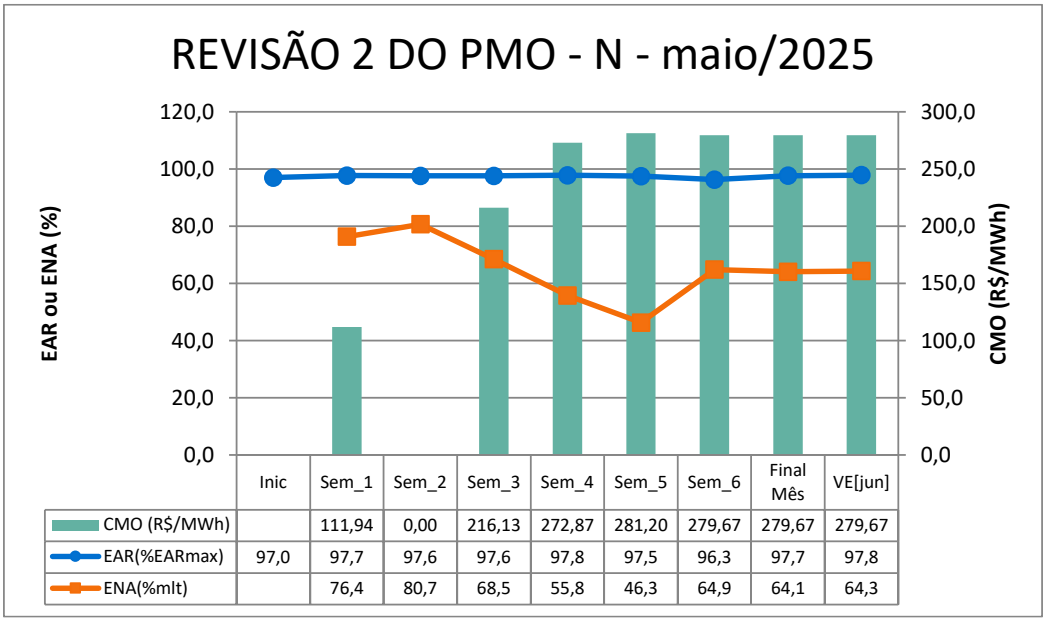

	Inic	Sem_1	Sem_2	Sem_3	Sem_4	Sem_5	Sem_6	Final Mês	VE[jun]
CMO (R$/MWh)		111,94	0,00	216,13	272,87	281,20	279,67	279,67	279,67
EAR(%EARmax)	97,0	97,7	97,6	97,6	97,8	97,5	96,3	97,7	97,8
ENA(%mlt)		76,4	80,7	68,5	55,8	46,3	64,9	64,1	64,3

O conteúdo desta publicação foi produzido pelo ONS com base em dados e informações de conhecimento público. É de responsabilidade exclusiva dos agentes e demais interessados a obtenção de outros dados e informações, a realização de análises, estudos e avaliações para fins de tomada de decisões, definição de estratégias de atuação, assunção de compromissos e obrigações e quaisquer outras finalidades, em qualquer tempo e sob qualquer condição. É proibida a reprodução ou utilização total ou parcial do presente sem a identificação da fonte.

7. ARMAZENAMENTOS OPERATIVOS

Para uma melhor avaliação de diversos cenários hidrometeorológicos, notadamente, aqueles de curto prazo e suas influências nas previsões de vazões nos subsistemas, os resultados desta revisão do PMO contemplam cenários de afluências visando melhor representar a ocorrência de precipitação e, consequentemente, seus efeitos sobre as afluências e armazenamentos.

Apresentamos a seguir as correspondentes energias naturais afluentes e os resultados obtidos com a aplicação do cenário de afluência utilizado no estudo.

Tabela 10 – Previsão de ENA do caso de valor esperado das previsões de afluência

Subsistema	ENERGIAS NATURAIS AFLUENTES			
	Previsão Semanal		Previsão Mensal	
	(MWmed)	%MLT	(MWmed)	%MLT
SE/CO	33.960	85	34.389	86
Sul	3.060	36	2.892	34
Nordeste	3.351	49	2.969	43
Norte	13.699	67	13.121	64

Tabela 11 – Previsão de %EARmáx para o final do mês

Subsistema	% EARmáx 09/05	% EARmáx - 31/05
	NÍVEL INICIAL	NÍVEL PMO
SE/CO	70,2	70,1
Sul	37,5	34,3
Nordeste	76,2	73,4
Norte	97,6	97,3

O conteúdo desta publicação foi produzido pelo ONS com base em dados e informações de conhecimento público. É de responsabilidade exclusiva dos agentes e demais interessados a obtenção de outros dados e informações, a realização de análises, estudos e avaliações para fins de tomada de decisões, definição de estratégias de atuação, assunção de compromissos e obrigações e quaisquer outras finalidades, em qualquer tempo e sob qualquer condição. É proibida a reprodução ou utilização total ou parcial do presente sem a identificação da fonte.

8. RESERVATÓRIOS EQUIVALENTES DE ENERGIA

A seguir são apresentadas as previsões de Energia Natural Afluente para a próxima semana operativa e para o mês de maio, bem como as previsões de Energia Armazenada nos Reservatórios Equivalentes de Energia – REE, desta revisão do PMO de Maio de 2025.

Tabela 12 – Previsão de ENA por REE

Valor Esperado das Energias Naturais Afluentes				
REE	Previsão Semanal		Previsão Mensal	
	10/05/2025 a 16/05/2025		mai/25	
	(MWmed)	%MLT	(MWmed)	%MLT
Sudeste	3.298	71	3.402	73
Madeira	10.910	123	10.524	119
Teles Pires	2.481	115	2.412	112
Itaipu	2.626	76	2.888	83
Paraná	13.496	73	14.011	76
Paranapanema	1.143	49	1.146	49
Sul	1.574	35	1.359	30
Iguaçu	1.486	37	1.532	38
Nordeste	3.351	49	2.969	43
Norte	5.376	58	5.087	55
Belo Monte	7.218	76	6.828	72
Manaus	1.431	83	1.579	92

Tabela 13 – Previsão de %EARmáx por REE

% Energia Armazenável Máxima		
REE	Previsão Semanal	Previsão Mensal
	16-mai	31-mai
	(%EARmáx)	(%EARmáx)
Sudeste	74,1	74,0
Madeira	100,0	99,5
Teles Pires	100,0	99,3
Itaipu	99,3	99,7
Paraná	69,9	69,3
Paranapanema	65,2	59,6
Sul	30,2	30,0
Iguaçu	43,1	38,6
Nordeste	75,7	73,4
Norte	98,9	98,4
Belo Monte	69,4	78,1
Manaus	75,1	79,8

O conteúdo desta publicação foi produzido pelo ONS com base em dados e informações de conhecimento público. É de responsabilidade exclusiva dos agentes e demais interessados a obtenção de outros dados e informações, a realização de análises, estudos e avaliações para fins de tomada de decisões, definição de estratégias de atuação, assunção de compromissos e obrigações e quaisquer outras finalidades, em qualquer tempo e sob qualquer condição. É proibida a reprodução ou utilização total ou parcial do presente sem a identificação da fonte.

9. DESPACHO TÉRMICO POR MODALIDADE, PATAMAR DE CARGA E USINA

Nas tabelas abaixo, a diferenciação entre geração por inflexibilidade e por ordem de mérito tem caráter informativo, com o objetivo de detalhar a informação de inflexibilidade enviada pelos respectivos agentes para esta revisão do PMO. Ressalta-se que nas etapas de Programação Diária e Tempo Real, o montante despachado nas usinas termelétricas indicadas por ordem de mérito é plenamente intitulado como ordem de mérito.

Tabela 14 – Despachos de Geração Térmica

REGIÃO SUDESTE/CENTRO-OESTE																	
Térmicas Potência (MW)	Combustível	CVU	Inflexibilidade			Ordem de Mérito			Total Mérito e INFL.			Razão Elétrica			Total UTE		
			P	M	L	P	M	L	P	M	L	P	M	L	P	M	L
ATLAN_CSA (255)	Resíduos	0,00	6,2	6,2	6,2				6,2	6,2	6,2				6,2	6,2	6,2
DAIA (44)	Diesel	---															
TNORTE 2 (349)	Óleo	---															
W.ARJONA O (177)	Diesel	---															
XAVANTES (54)	Diesel	---															
ANGRA 2 (1350)	Nuclear	20,12	1350,0	1350,0	1350,0	0,0	0,0	0,0	1350,0	1350,0	1350,0				1350,0	1350,0	1350,0
ANGRA 1 (640)	Nuclear	31,17				0,0	0,0	0,0									
O.PINTADA (50)	Biomassa	145,52	30,0	30,0	30,0	20,0	20,0	20,0	50,0	50,0	50,0				50,0	50,0	50,0
M.AZUL (566)	Gás	147,02				0,0	0,0	0,0									
UTE STA VI (41)	Biomassa	157,20	18,0	18,0	18,0	23,0	23,0	23,0	41,0	41,0	41,0				41,0	41,0	41,0
BAIXADA FL (530)	Gás	229,17	416,0	352,0	130,0	114,0	178,0	400,0	530,0	530,0	530,0				530,0	530,0	530,0
SANTA CRUZ (500)	GNL	232,91															
ATLANTICO (235)	Resíduos	256,07	134,2	134,2	134,2	0,0	0,0		134,2	134,2	134,2				134,2	134,2	134,2
ST.CRUZ 34 (436)	Óleo	310,41															
LUIZORMELO (204)	GNL	352,56															
CUBATAO (216)	Gás	422,58	209,0	209,0	110,0				209,0	209,0	110,0				209,0	209,0	110,0
UTE GNA I (1338)	Gás	444,80															
PIRAT.12 O (200)	Gás	470,34															
IBIRITE (235)	Gás	756,11	188,0	159,1	72,3				188,0	159,1	72,3				188,0	159,1	72,3
TERMORIO (989)	Gás	854,27	600,0	507,0	360,0				600,0	507,0	360,0				600,0	507,0	360,0
KARKEY 013 (259)	Gás	861,35	30,6	30,6	30,6				30,6	30,6	30,6				30,6	30,6	30,6
KARKEY 019 (116)	Gás	861,35															
T.LAGOAS (350)	Gás	896,08															
T.MACAE (922)	Gás	956,38	675,0	260,0					675,0	260,0					675,0	260,0	0,0
PORSUD I (116)	Gás	1014,97															
PORSUD II (78)	Gás	1015,15															
NORTEFLU (826)	Gás	1022,99															
CUIABA CC (529)	Gás	1027,52															
J.FORA (87)	Gás	1089,46															
SEROPEDICA (360)	Gás	1139,38															
VIANA (175)	Óleo	1229,79															
PAULINIA (16)	Gás	1231,71	15,7	15,7	15,7				15,7	15,7	15,7				15,7	15,7	15,7
LORM_PCS (36)	Gás	1250,98															
POVOACAO I (75)	Gás	1250,98															
VIANA I (37)	Gás	1250,98															
NPIRATINGA (572)	Gás	1298,26	280,0	108,0					280,0	108,0					280,0	108,0	0,0
PALMEIR_GO (176)	Diesel	1437,98															
W.ARJONA (177)	Gás	1547,17															
TOTAL SE/CO (13316)			3952,7	3179,8	2257,0	157,0	221,0	443,0	4109,7	3400,8	2700,0	0,0	0,0	0,0	4109,7	3400,8	2700,0

REGIÃO SUL																	
Térmicas Potência (MW)	Combustível	CVU	Inflexibilidade			Ordem de Mérito			Total Mérito e INFL.			Razão Elétrica			Total UTE		
			P	M	L	P	M	L	P	M	L	P	M	L	P	M	L
CANDIOTA_3 (350)	Carvão	---															
PAMPA SUL (345)	Carvão	101,20				0,0	0,0	0,0									
SAO SEPE (8)	Biomassa	113,53	4,0	4,0	4,0	4,0	4,0	4,0	8,0	8,0	8,0				8,0	8,0	8,0
FIGUEIRA (20)	Carvão	330,64															
J.LACER. C (330)	Carvão	341,04	330,0	330,0	330,0				330,0	330,0	330,0				330,0	330,0	330,0
J.LACER. B (220)	Carvão	397,24	110,0	110,0	110,0				110,0	110,0	110,0				110,0	110,0	110,0
J.LAC. A2 (110)	Carvão	406,63	110,0	93,0	56,0				110,0	93,0	56,0				110,0	93,0	56,0
J.LAC. A1 (80)	Carvão	475,13															
ARAUCARIA (484)	Gás	754,44															
B.BONITA I (10)	Gás	778,35															
URUGUAIANA (640)	Gás	823,99															
CANOAS (249)	Gás	1329,55															
TOTAL SUL (2846)			554,0	537,0	500,0	4,0	4,0	4,0	558,0	541,0	504,0	0,0	0,0	0,0	558,0	541,0	504,0

O conteúdo desta publicação foi produzido pelo ONS com base em dados e informações de conhecimento público. É de responsabilidade exclusiva dos agentes e demais interessados a obtenção de outros dados e informações, a realização de análises, estudos e avaliações para fins de tomada de decisões, definição de estratégias de atuação, assunção de compromissos e obrigações e quaisquer outras finalidades, em qualquer tempo e sob qualquer condição. É proibida a reprodução ou utilização total ou parcial do presente sem a identificação da fonte.

REGIÃO NORDESTE

Térmicas Potência (MW)	Combustível	CVU	Inflexibilidade			Ordem de Mérito			Total Mérito e INFL.			Razão Elétrica			Total UTE		
			P	M	L	P	M	L	P	M	L	P	M	L	P	M	L
CAMPINA_GR (169)	Óleo	---															
GLOBAL I (149)	Óleo	---															
GLOBAL II (149)	Óleo	---															
MARACANAU (168)	Óleo	---															
PETROLINA (136)	Óleo	---															
POTIGUAR (53)	Diesel	---															
POTIGUAR_3 (66)	Diesel	---															
TERMOCABO (50)	Óleo	---															
TERMONE (171)	Óleo	---															
TERMOPB (171)	Óleo	---															
ERB CANDEI (17)	Biomassa	113,61	3,5	3,5	3,5	8,5	8,5	8,5	12,0	12,0	12,0				12,0	12,0	12,0
PROSP_I (28)	Gás	214,28				28,0	28,0	28,0	28,0	28,0	28,0				28,0	28,0	28,0
PROSP_III (56)	Gás	218,33				56,0			56,0						56,0	0,0	0,0
PROSP_II (37)	Gás	323,01															
PSERGIPE I (1593)	GNL	335,41															
P.PECEM1 (720)	Carvão	336,80															
P.PECEM2 (365)	Carvão	344,79															
VALE ACU (110)	Gás	450,86															
T.BAHIA (186)	Gás	654,25															
PERNAMBU_3 (201)	Óleo	855,73															
TERMOPE (550)	Gás	920,48															
SUAPE II (381)	Óleo	1013,16															
TERMOCEARA (223)	Gás	2031,41															
C.MURICY 2 (144)	Óleo	2422,67															
PECEM 2 (144)	Óleo	2447,92															
TOTAL NE (5749)			3,5	3,5	3,5	92,5	36,5	36,5	96,0	40,0	40,0	0,0	0,0	0,0	96,0	40,0	40,0

REGIÃO NORTE

Térmicas Potência (MW)	Combustível	CVU	Inflexibilidade			Ordem de Mérito			Total Mérito e INFL.			Razão Elétrica			Total UTE		
			P	M	L	P	M	L	P	M	L	P	M	L	P	M	L
C. ROCHA (85)	Gás	0,00	65,0	65,0	65,0				65,0	65,0	65,0				65,0	65,0	65,0
MANAUARA (73)	Gás	0,00	65,0	66,2	68,9				65,0	66,2	68,9				65,0	66,2	68,9
PONTA NEGR (73)	Gás	0,00	64,0	64,0	64,0				64,0	64,0	64,0				64,0	64,0	64,0
MARANHAO3 (519)	Gás	110,91				501,5	500,6	513,6	501,5	500,6	513,6				501,5	500,6	513,6
APARECIDA (166)	Gás	114,90	75,0	75,0	75,0	48,0	48,0	48,0	123,0	123,0	123,0				123,0	123,0	123,0
JARAQUI (75)	Gás	114,90	29,0	29,0	29,0	34,0	34,0	34,0	63,0	63,0	63,0				63,0	63,0	63,0
TAMBAQUI (93)	Gás	114,90	33,0	33,0	33,0	30,0	30,0	30,0	63,0	63,0	63,0				63,0	63,0	63,0
UTE MAUA 3 (591)	Gás	114,90	264,0	264,0	264,0	263,5	273,2	294,3	527,5	537,2	558,3				527,5	537,2	558,3
MARANHAO V (338)	Gás	215,57				330,0	0,0	174,9	330,0		174,9				330,0	0,0	174,9
MARANHAOIV (338)	Gás	215,57				330,0	0,0	0,0	330,0						330,0	0,0	0,0
PARNAIBA_V (386)	Vapor	238,34															
N.VENECIA2 (270)	Gás	294,56															
P. ITAQUI (360)	Carvão	336,84															
PARNAIB_IV (56)	Gás	430,66															
GERAMAR1 (166)	Óleo	1286,18															
GERAMAR2 (166)	Óleo	1286,18															
TOTAL NORTE (4045)			595,0	596,2	598,9	1537,0	885,8	1094,8	2132,0	1482,0	1693,7	0,0	0,0	0,0	2132,0	1482,0	1693,7

O conteúdo desta publicação foi produzido pelo ONS com base em dados e informações de conhecimento público. É de responsabilidade exclusiva dos agentes e demais interessados a obtenção de outros dados e informações, a realização de análises, estudos e avaliações para fins de tomada de decisões, definição de estratégias de atuação, assunção de compromissos e obrigações e quaisquer outras finalidades, em qualquer tempo e sob qualquer condição. É proibida a reprodução ou utilização total ou parcial do presente sem a identificação da fonte.