1. APRESENTAÇÃO

Na semana de 07/02 a 13/02/2026, houve precipitação nas bacias dos rios Tietê, Grande e Paranaíba. Nas bacias hidrográficas da Região Norte ocorreram pancadas de chuva no decorrer da semana.

Na semana de 14/02 a 20/02/2026, deve permanecer a ocorrência de pancadas de chuva nas bacias da Região Norte. Para a referida semana operativa os maiores totais de precipitação estão previstos para as bacias dos rios Uruguai, Taquari-Antas, Iguaçu e Madeira.

Os valores médios semanais do Custo Marginal de Operação – CMO dos subsistemas do SIN sofreram as seguintes alterações em relação à semana anterior:

- SE/CO: de R$ 382,93/MWh para R$ 309,25/MWh
- Sul: de R$ 382,93/MWh para R$ 325,90/MWh
- Nordeste: de R$ 382,05/MWh para R$ 309,25/MWh
- Norte: de R$ 382,05/MWh para R$ 309,25/MWh

Desde o dia 01/01/2020, o despacho por ordem de mérito é indicado diariamente pelos resultados do modelo DESSEM. Assim, o despacho por ordem de mérito semanal, conforme publicado nesse documento, tem caráter apenas informativo. Da mesma forma, desde o dia 01/01/2021, a formação de preço deixou o formato semanal/patamar de carga e passou a ser horário, de acordo também com os resultados do modelo DESSEM.

2. NOTÍCIAS

Nos dias 26 e 27 de fevereiro será realizada a reunião de elaboração do PMO de Março de 2026, com transmissão ao vivo através do site do ONS.

3. INFORMAÇÕES CONJUNTURAIS PARA ELABORAÇÃO DO PMO

3.1. Informações hidrometeorológicas

3.1.1. Condições antecedentes

No início da semana, a passagem de uma frente fria pela Região Sul ocasionou precipitação abaixo da média semanal nas bacias hidrográficas dessa região. Ao avançar pelo litoral da Região Sudeste, esse sistema contribuiu para a manutenção da Zona de Convergência do Atlântico Sul (ZCAS) sobre as Regiões Sudeste e Centro-Oeste, favorecendo a ocorrência de precipitação entre a média e acima da média nas bacias dos rios Tietê, Grande e Paranaíba. Nas bacias hidrográficas da Região Norte ocorreram pancadas de chuva no decorrer da semana (Figura 1).

O conteúdo desta publicação foi produzido pelo ONS com base em dados e informações de conhecimento público. É de responsabilidade exclusiva dos agentes e demais interessados a obtenção de outros dados e informações, a realização de análises, estudos e avaliações para fins de tomada de decisões, definição de estratégias de atuação, assunção de compromissos e obrigações e quaisquer outras finalidades, em qualquer tempo e sob qualquer condição. É proibida a reprodução ou utilização total ou parcial do presente sem a identificação da fonte.

Figura 1 – Precipitação observada (mm) no período de 07/02 a 12/02/2026

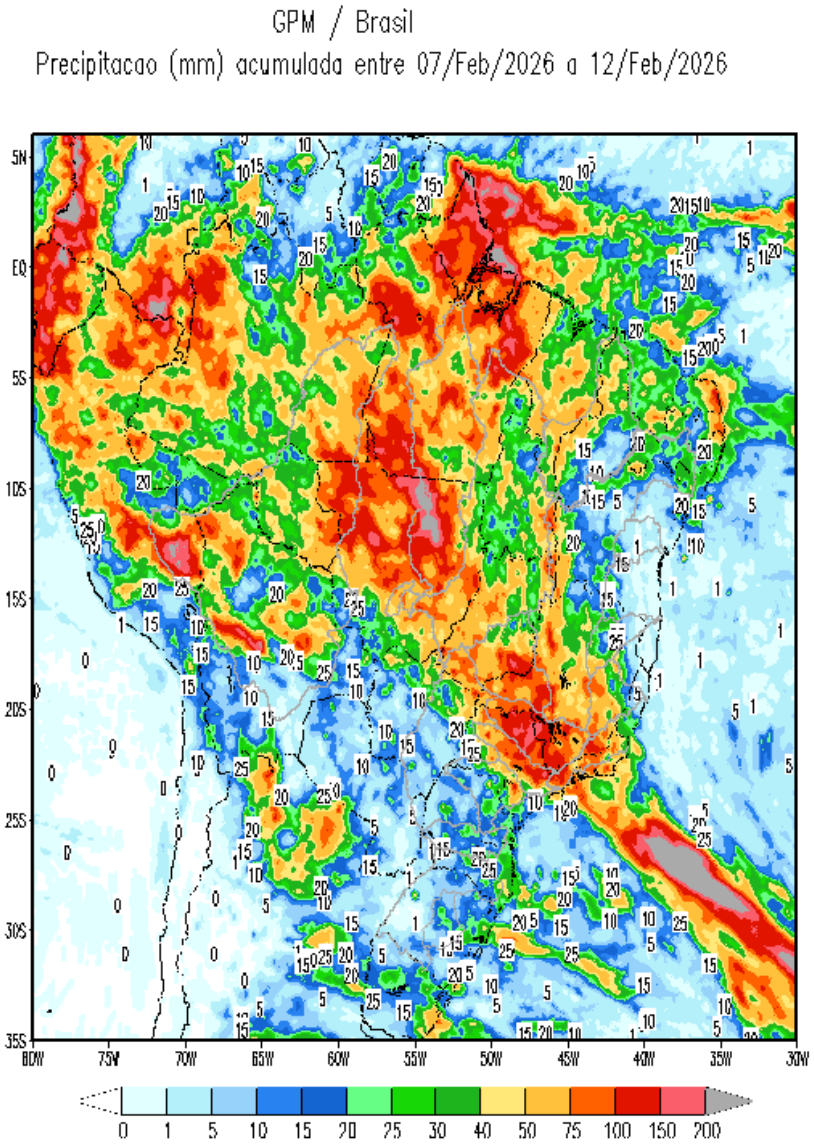

A Tabela 1 apresenta as energias naturais afluentes das semanas recentes. São apresentados os valores verificados na semana 31/01/2026 a 06/02/2026 e os estimados para fechamento da semana de 07/02/2026 a 13/02/2026.

Tabela 1 – Tendência hidrológica da ENA da Revisão 2 de Fevereiro/2026

Revisão 2 do PMO de Fevereiro/2026 - ENAs				
Subsistema	31/01 a 06/02/2026		07/02 a 13/02/2026	
	MWmed	%MLT	MWmed	%MLT
SE/CO	61.823	88	69.331	98
S	3.381	41	3.216	39
NE	7.786	55	12.284	87
N	11.482	53	12.313	54

O conteúdo desta publicação foi produzido pelo ONS com base em dados e informações de conhecimento público. É de responsabilidade exclusiva dos agentes e demais interessados a obtenção de outros dados e informações, a realização de análises, estudos e avaliações para fins de tomada de decisões, definição de estratégias de atuação, assunção de compromissos e obrigações e quaisquer outras finalidades, em qualquer tempo e sob qualquer condição. É proibida a reprodução ou utilização total ou parcial do presente sem a identificação da fonte.

3.1.2. Previsão para a próxima semana

A próxima semana inicia com a rápida passagem de uma frente fria pela Região Sul, ocasionando precipitação nas bacias dessa região. Ao longo da semana, um sistema de baixa pressão se forma próximo ao litoral do Rio Grande do Sul, sendo que uma frente fria associada a esse sistema se deslocará pelos demais estados da Região Sul e pelo litoral de São Paulo ocasionando precipitação dentro da média semanal nas bacias da Região Sul e abaixo da média nas bacias das Regiões Sudeste e Centro-Oeste. As bacias da Região Norte permanecem com a ocorrência de pancadas de chuvas no decorrer da semana. Os maiores totais de precipitação estão previstos para as bacias dos rios Uruguai, Taquari-Antas, Iguaçu e Madeira (Figura 2).

Figura 2 - Precipitação acumulada prevista pelo modelo ECMWF - período de 14 a 20/02/2026

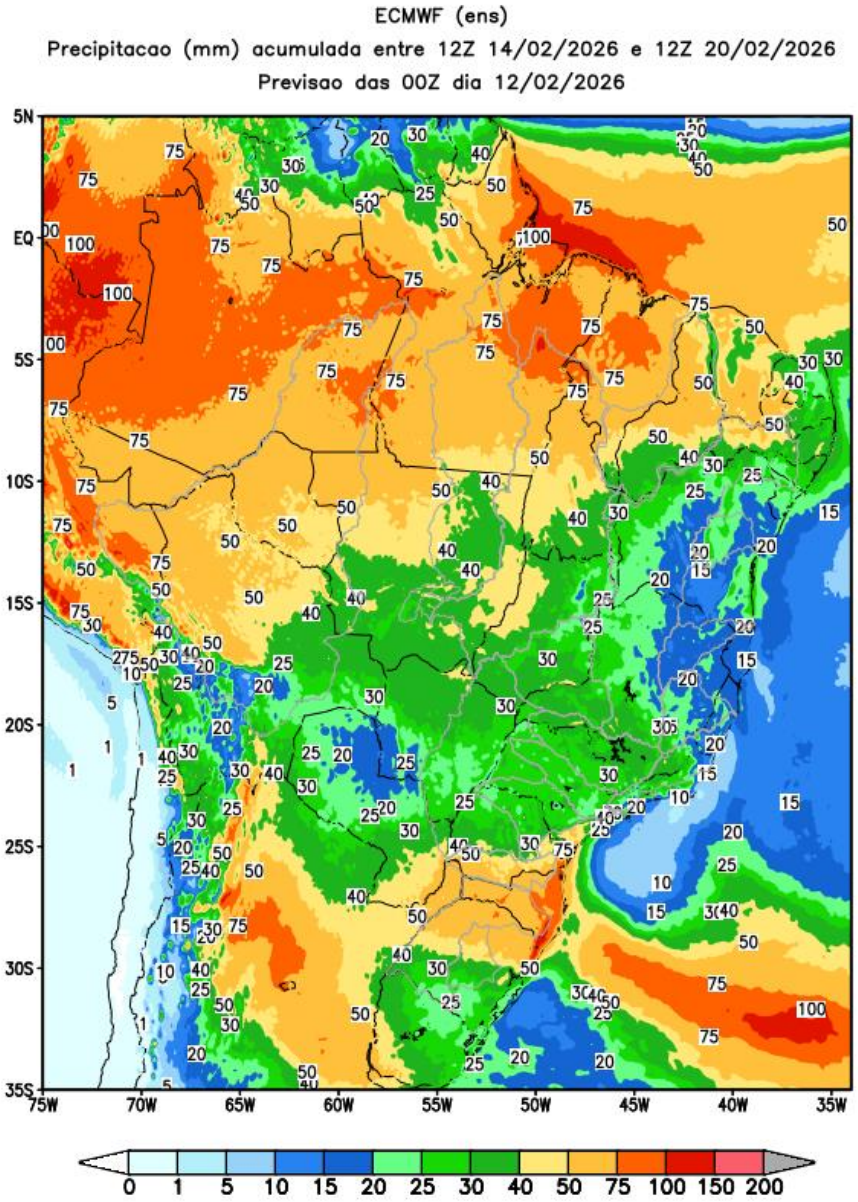

Em comparação com os valores estimados para a semana em curso, prevê-se para a próxima semana operativa ascensão nas afluências dos subsistemas Sul, Nordeste e Norte e recessão nas afluências do subsistema Sudeste/Centro-Oeste. A previsão mensal para fevereiro indica a ocorrência de afluências abaixo da média histórica para todos os subsistemas.

O conteúdo desta publicação foi produzido pelo ONS com base em dados e informações de conhecimento público. É de responsabilidade exclusiva dos agentes e demais interessados a obtenção de outros dados e informações, a realização de análises, estudos e avaliações para fins de tomada de decisões, definição de estratégias de atuação, assunção de compromissos e obrigações e quaisquer outras finalidades, em qualquer tempo e sob qualquer condição. É proibida a reprodução ou utilização total ou parcial do presente sem a identificação da fonte.

Tabela 2 – Previsão de ENAs da Revisão 2 de Fevereiro/2026

Revisão 2 do PMO de Fevereiro/2026 - ENAs previstas				
Subsistema	14/02 a 20/02/2026		Mês de fevereiro	
	MWmed	%MLT	MWmed	%MLT
SE/CO	60.638	86	62.630	88
S	5.455	66	3.869	47
NE	15.482	109	12.946	91
N	12.489	55	13.078	58

As figuras a seguir ilustram as ENAs semanais verificadas e previstas para as Revisões 1 e 2 do PMO de Fevereiro/2026.

Figura 3 - Energias Naturais Afluentes ao Subsistema Sudeste/Centro-Oeste das Revisões 1 e 2 do PMO de Fevereiro/2026

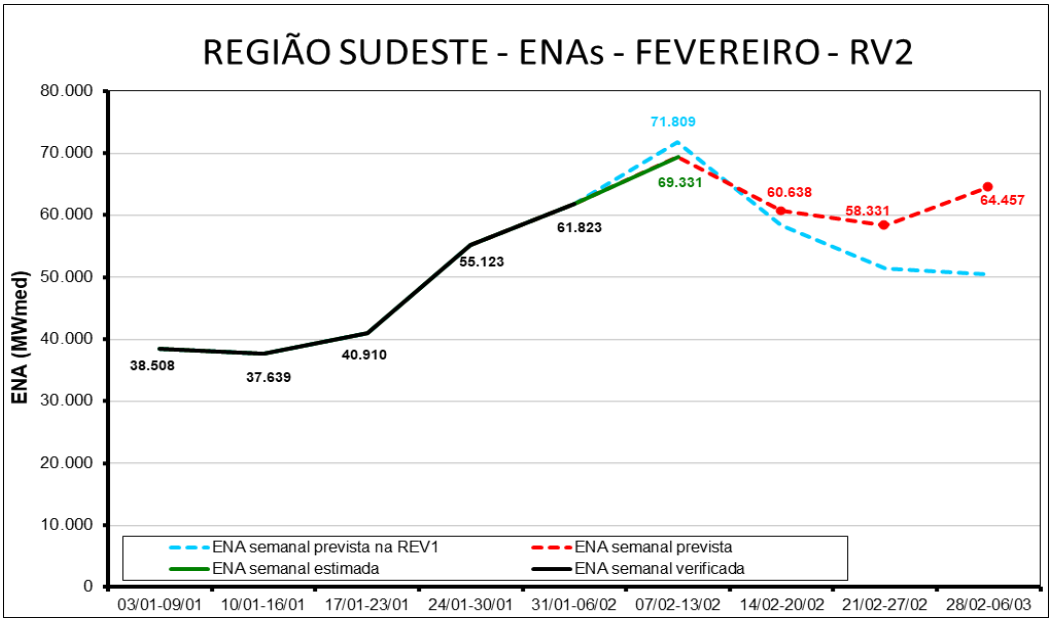

Figura 4 - Energias Naturais Afluentes ao Subsistema Sul das Revisões 1 e 2 do PMO de Fevereiro/2026

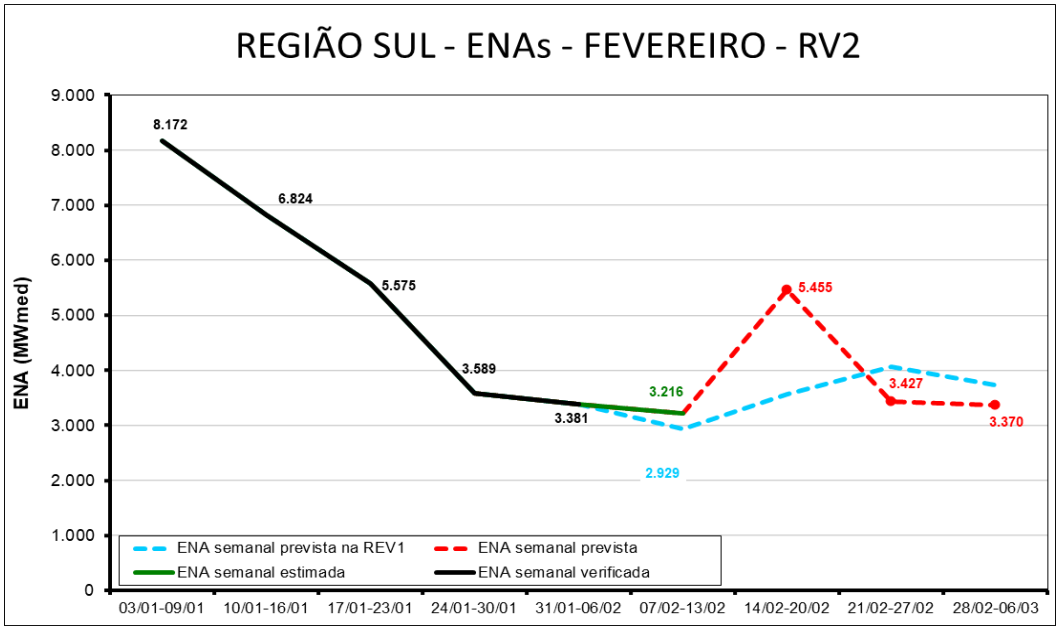

O conteúdo desta publicação foi produzido pelo ONS com base em dados e informações de conhecimento público. É de responsabilidade exclusiva dos agentes e demais interessados a obtenção de outros dados e informações, a realização de análises, estudos e avaliações para fins de tomada de decisões, definição de estratégias de atuação, assunção de compromissos e obrigações e quaisquer outras finalidades, em qualquer tempo e sob qualquer condição. É proibida a reprodução ou utilização total ou parcial do presente sem a identificação da fonte.

Figura 5 - Energias Naturais Afluentes ao Subsistema Nordeste das Revisões 1 e 2 do PMO de Fevereiro/2026

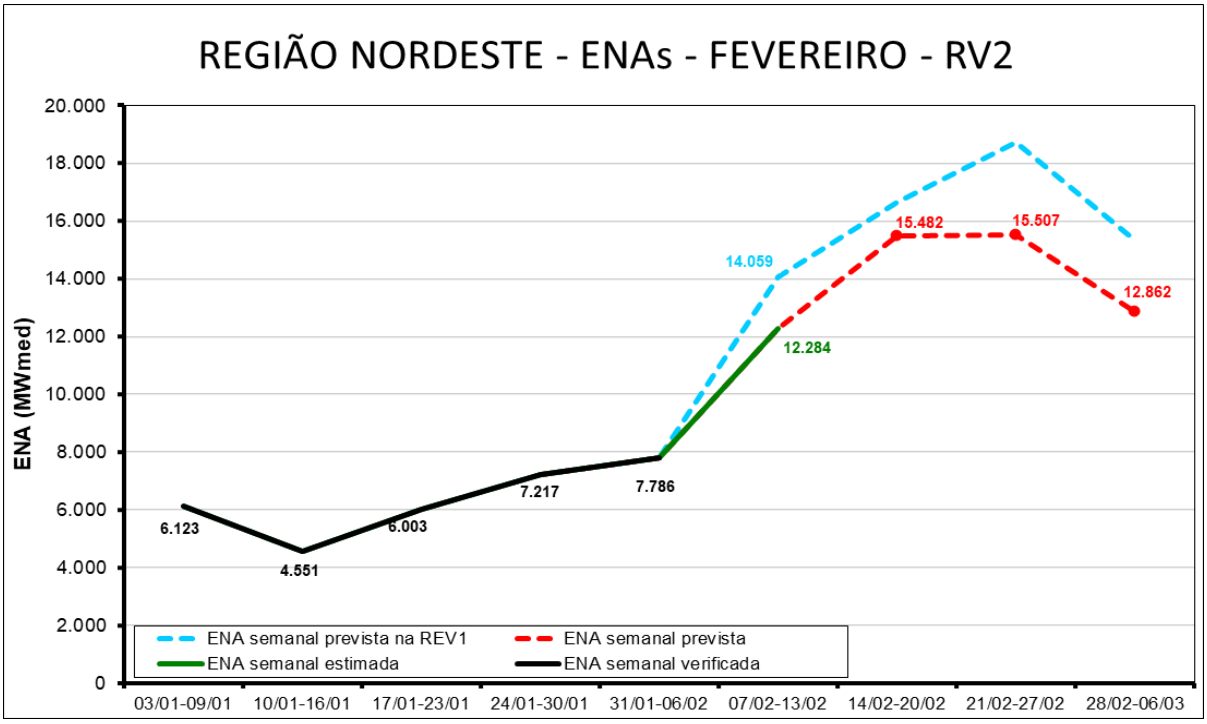

Figura 6 - Energias Naturais Afluentes ao Subsistema Norte das Revisões 1 e 2 do PMO de Fevereiro/2026

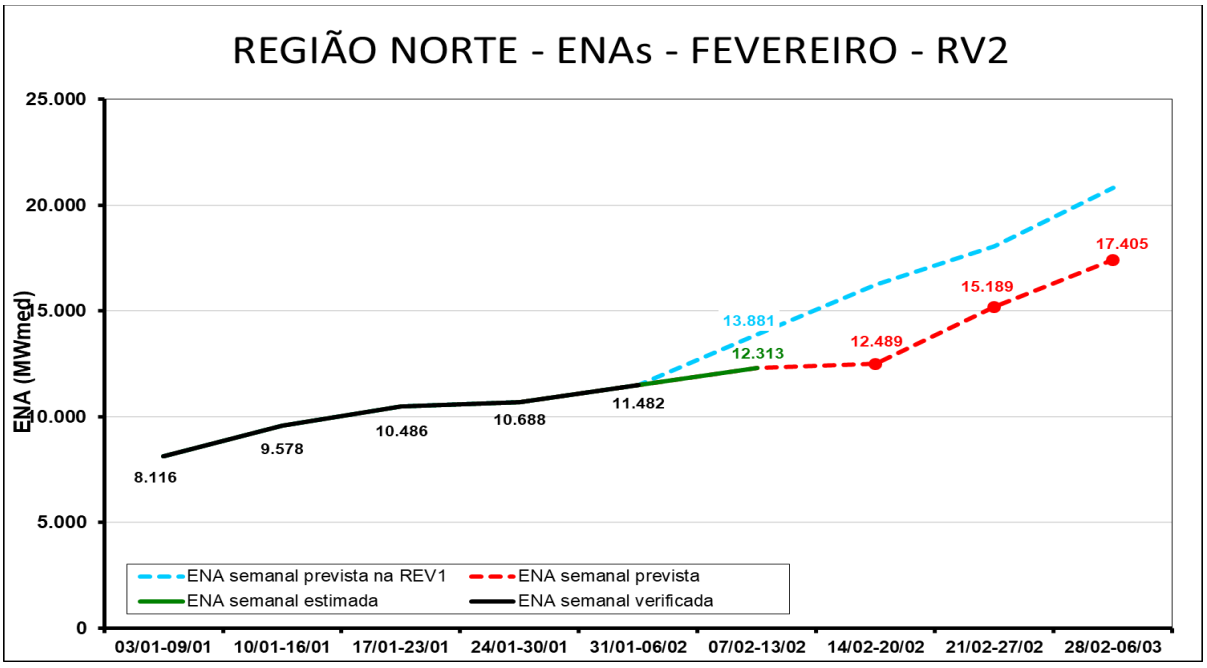

O conteúdo desta publicação foi produzido pelo ONS com base em dados e informações de conhecimento público. É de responsabilidade exclusiva dos agentes e demais interessados a obtenção de outros dados e informações, a realização de análises, estudos e avaliações para fins de tomada de decisões, definição de estratégias de atuação, assunção de compromissos e obrigações e quaisquer outras finalidades, em qualquer tempo e sob qualquer condição. É proibida a reprodução ou utilização total ou parcial do presente sem a identificação da fonte.

3.1.3. Cenários de ENAs para a Revisão 2 de Fevereiro/2026

As figuras a seguir apresentam as características dos cenários de energias naturais afluentes gerados na Revisão 2 de Fevereiro/2026, para acoplamento com a FCF do mês de março/2026. São mostradas, para os quatro subsistemas, as amplitudes e as Funções de Distribuição Acumulada dos cenários de ENA, comparativamente com os valores considerados para as revisões anteriores do PMO de Fevereiro/2026.

Figura 7 - Amplitude dos Cenários de ENA para o Subsistema Sudeste/Centro-Oeste, em %MLT, para a Revisão 2 de Fevereiro/2026

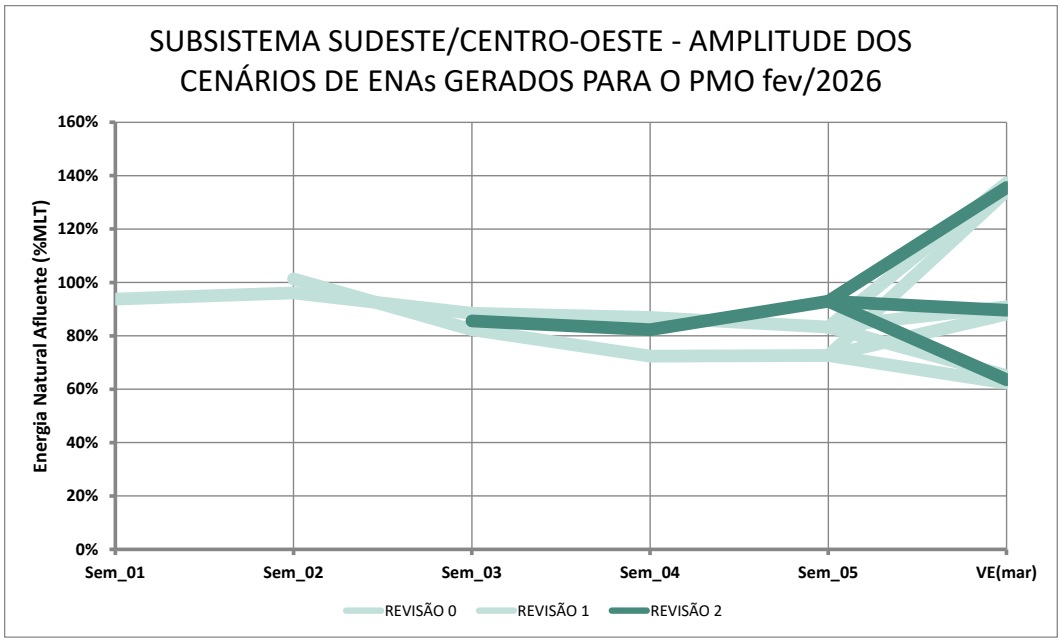

Figura 8 - Função de Distribuição Acumulada dos Cenários para o Subsistema Sudeste/Centro-Oeste para a Revisão 2 de Fevereiro/2026

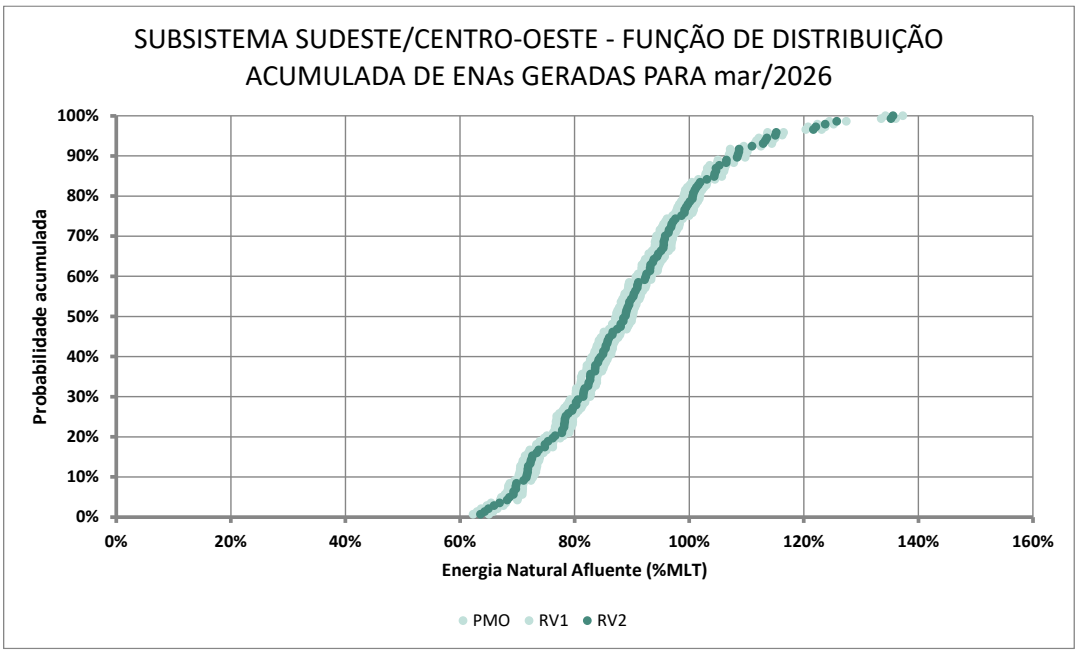

O conteúdo desta publicação foi produzido pelo ONS com base em dados e informações de conhecimento público. É de responsabilidade exclusiva dos agentes e demais interessados a obtenção de outros dados e informações, a realização de análises, estudos e avaliações para fins de tomada de decisões, definição de estratégias de atuação, assunção de compromissos e obrigações e quaisquer outras finalidades, em qualquer tempo e sob qualquer condição. É proibida a reprodução ou utilização total ou parcial do presente sem a identificação da fonte.

Figura 9 - Amplitude dos Cenários de ENA para o Subsistema Sul, em %MLT, para a Revisão 2 de Fevereiro/2026

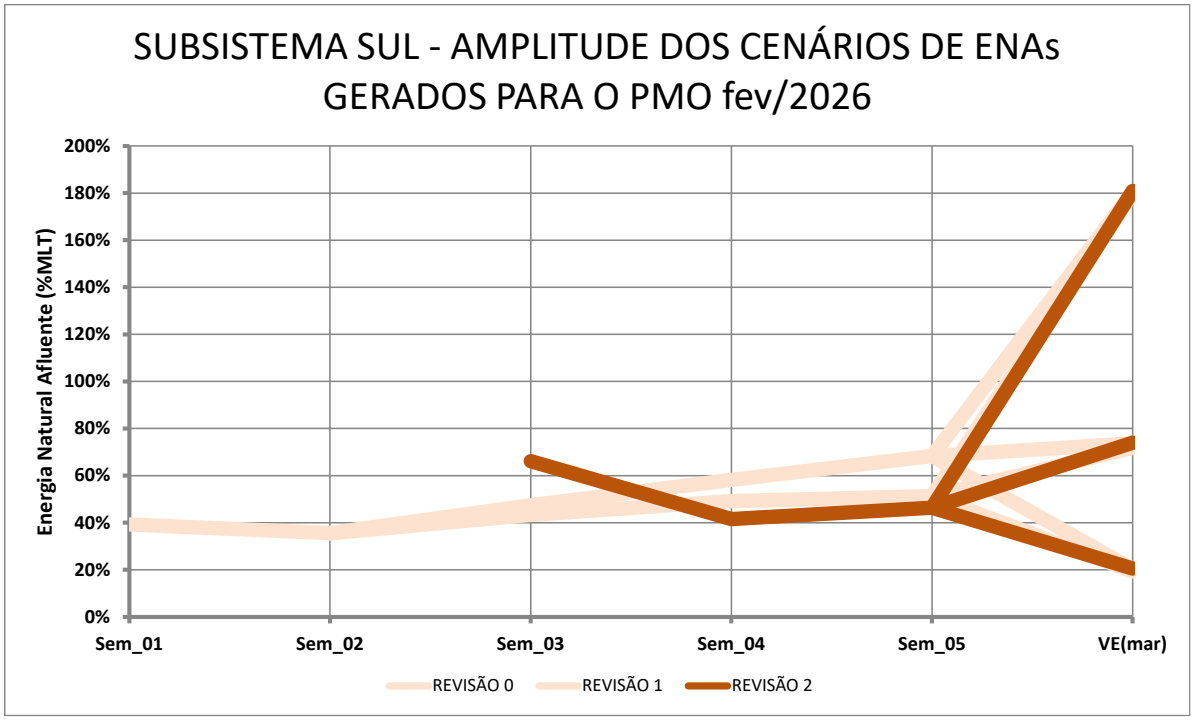

Figura 10 - Função de Distribuição Acumulada dos Cenários para o Subsistema Sul para a Revisão 2 de Fevereiro/2026

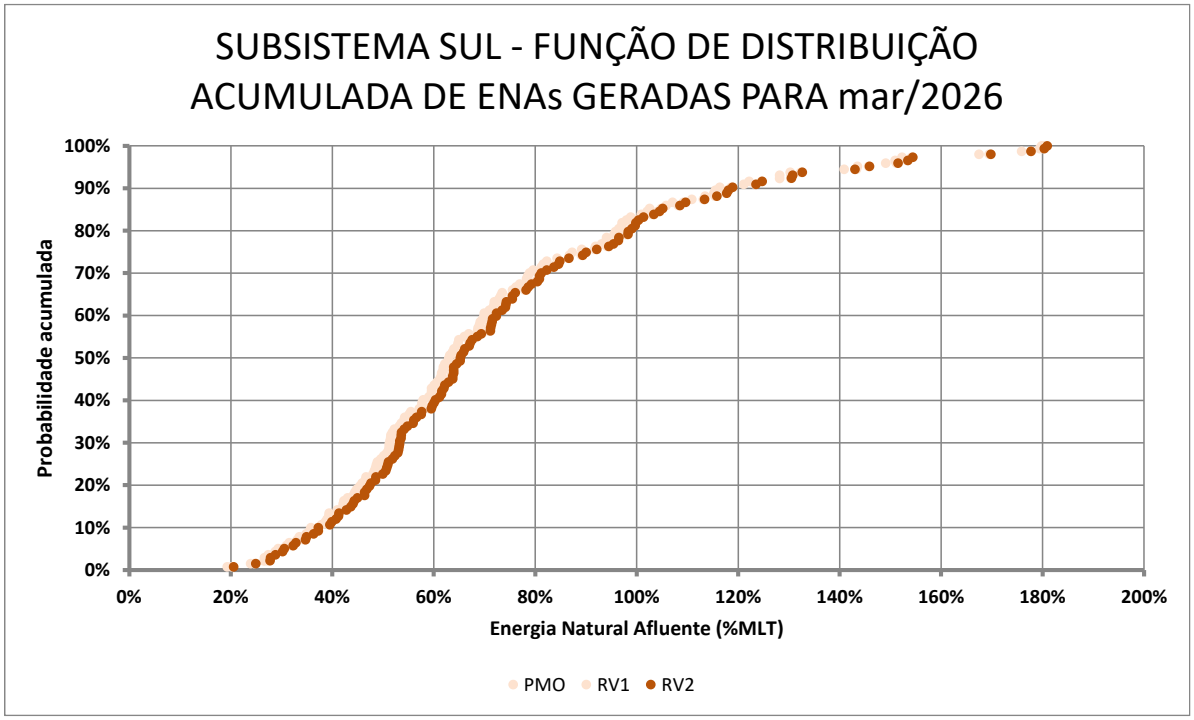

O conteúdo desta publicação foi produzido pelo ONS com base em dados e informações de conhecimento público. É de responsabilidade exclusiva dos agentes e demais interessados a obtenção de outros dados e informações, a realização de análises, estudos e avaliações para fins de tomada de decisões, definição de estratégias de atuação, assunção de compromissos e obrigações e quaisquer outras finalidades, em qualquer tempo e sob qualquer condição. É proibida a reprodução ou utilização total ou parcial do presente sem a identificação da fonte.

Figura 11 - Amplitude dos Cenários de ENA para o Subsistema Nordeste em %MLT, para a Revisão 2 de Fevereiro/2026

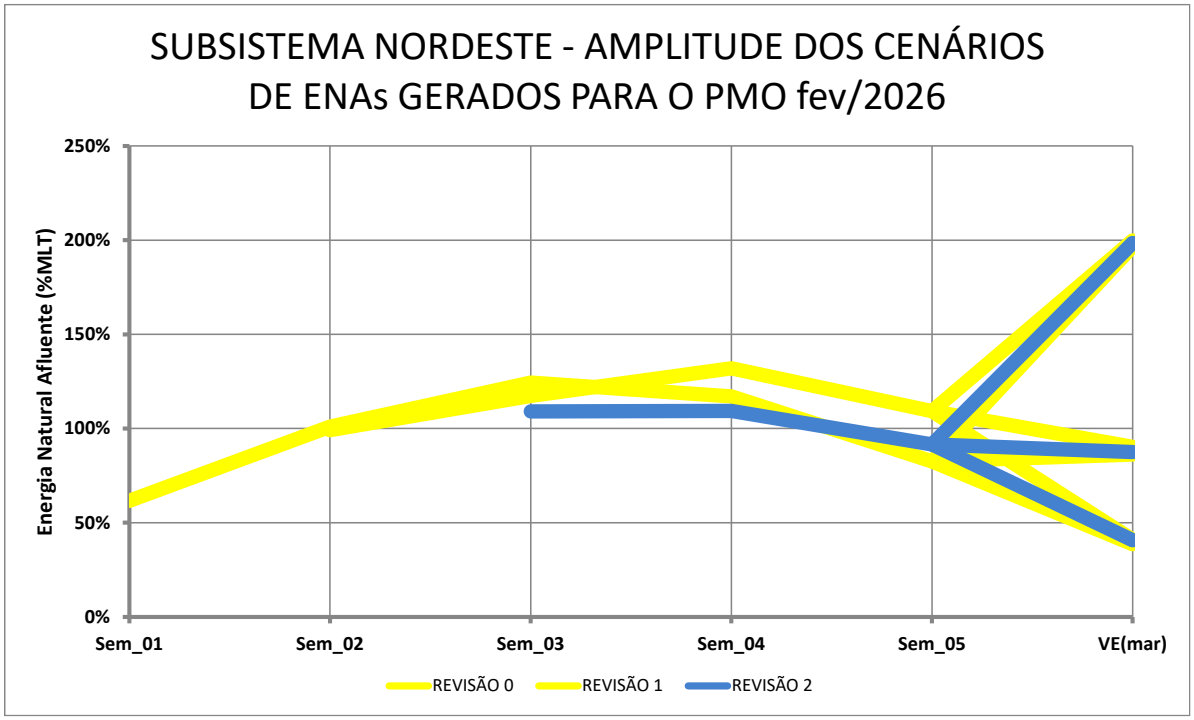

Figura 12 - Função de Distribuição Acumulada dos Cenários para o Subsistema Nordeste para a Revisão 2 de Fevereiro/2026

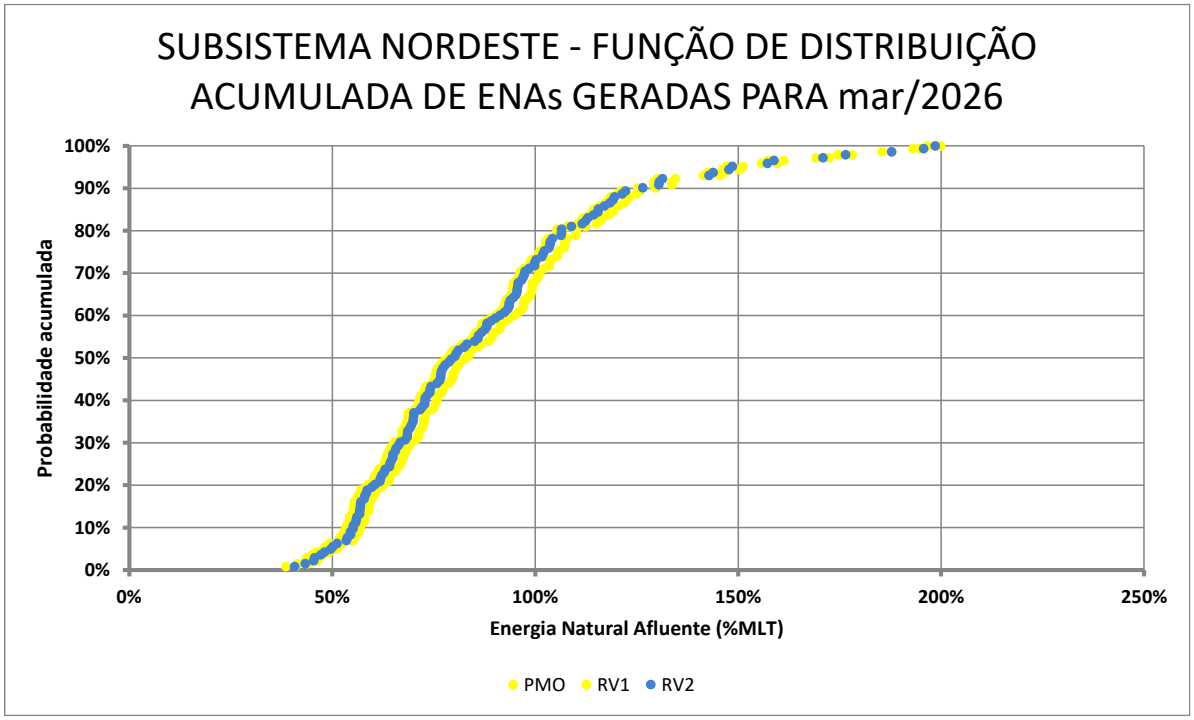

O conteúdo desta publicação foi produzido pelo ONS com base em dados e informações de conhecimento público. É de responsabilidade exclusiva dos agentes e demais interessados a obtenção de outros dados e informações, a realização de análises, estudos e avaliações para fins de tomada de decisões, definição de estratégias de atuação, assunção de compromissos e obrigações e quaisquer outras finalidades, em qualquer tempo e sob qualquer condição. É proibida a reprodução ou utilização total ou parcial do presente sem a identificação da fonte.

Figura 13 - Amplitude dos Cenários de ENA para o Subsistema Norte, em %MLT, para a Revisão 2 de Fevereiro/2026

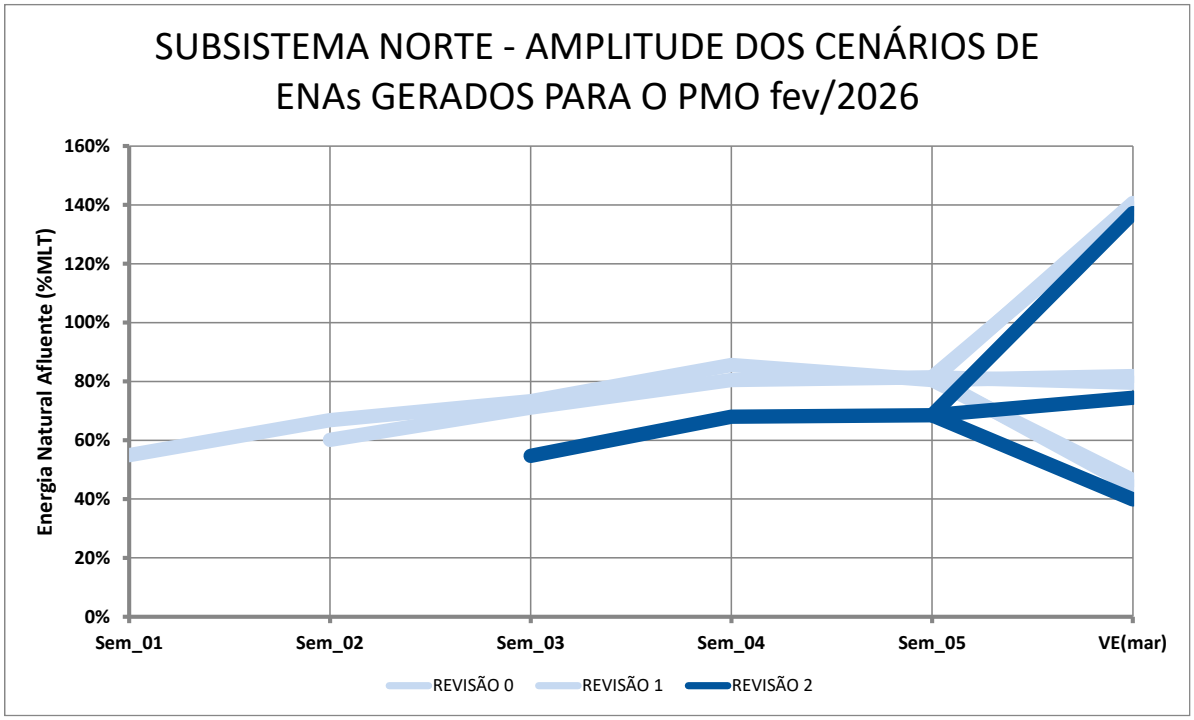

Figura 14 - Função de Distribuição Acumulada dos Cenários para o Subsistema Norte para a Revisão 2 de Fevereiro/2026

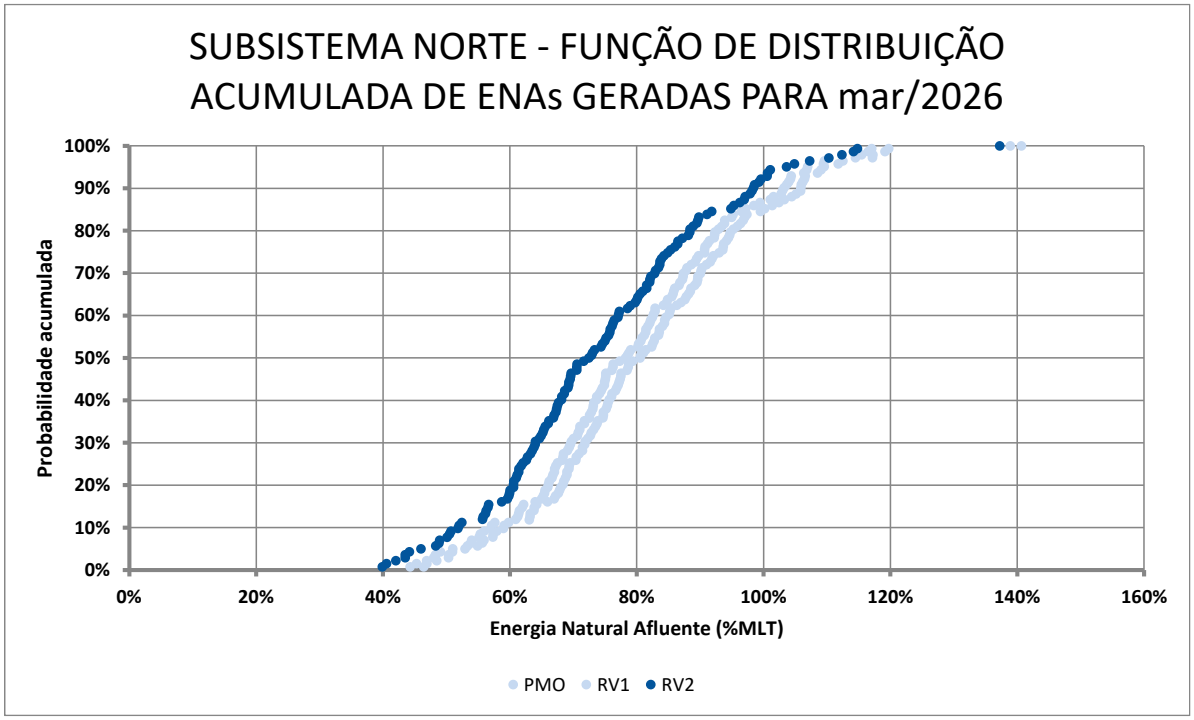

O conteúdo desta publicação foi produzido pelo ONS com base em dados e informações de conhecimento público. É de responsabilidade exclusiva dos agentes e demais interessados a obtenção de outros dados e informações, a realização de análises, estudos e avaliações para fins de tomada de decisões, definição de estratégias de atuação, assunção de compromissos e obrigações e quaisquer outras finalidades, em qualquer tempo e sob qualquer condição. É proibida a reprodução ou utilização total ou parcial do presente sem a identificação da fonte.

Os valores da MLT (Média de Longo Termo) das energias naturais afluentes para os meses de fevereiro/2026 e março/2026 são apresentados na tabela a seguir.

Tabela 3 – MLT da ENA nos meses de fevereiro/2026 e março/2026

MLT das ENAs (MWmed)		
Subsistema	fevereiro	março
SE/CO	70.844	69.061
S	8.249	7.105
NE	14.185	14.022
N	22.743	26.896

3.2. Limites de Intercâmbio entre Subsistemas

Os limites elétricos de intercâmbio de energia entre subsistemas são de fundamental importância para o processo de otimização energética, sendo determinantes para a definição das políticas de operação e do CMO para cada subsistema. Estes limites são influenciados por intervenções na malha de transmissão, notadamente na primeira semana operativa. O diagrama a seguir ilustra os fluxos notáveis do SIN e os limites aplicados neste PMO.

Figura 15 – Interligações entre regiões

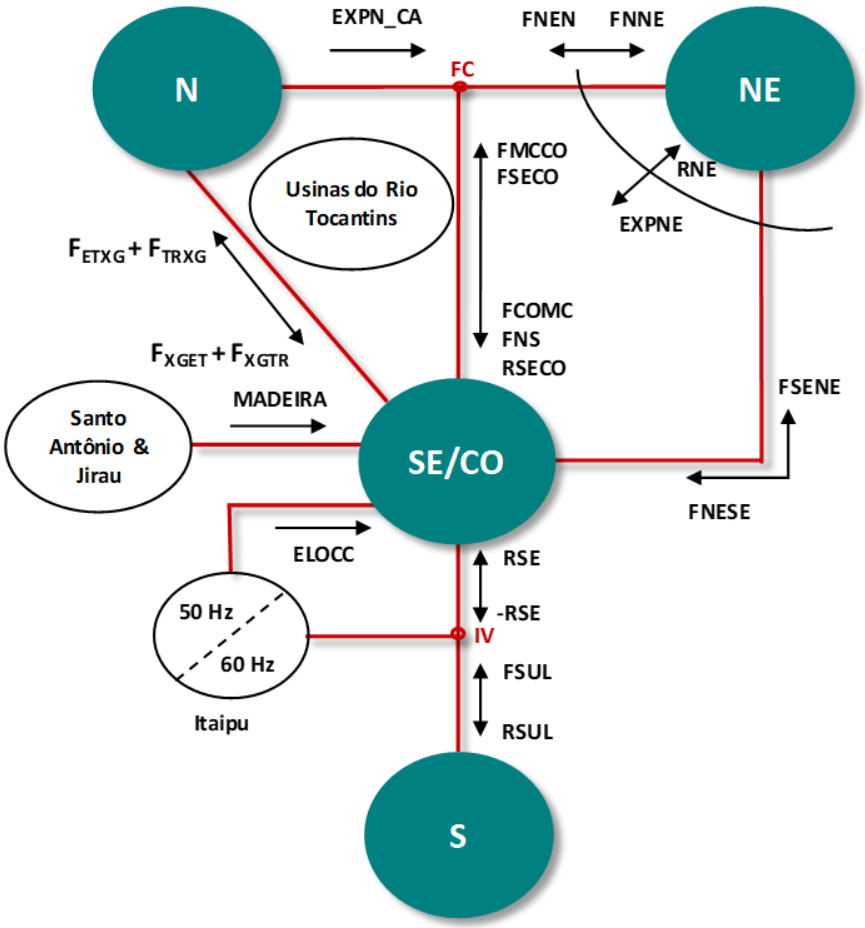

O conteúdo desta publicação foi produzido pelo ONS com base em dados e informações de conhecimento público. É de responsabilidade exclusiva dos agentes e demais interessados a obtenção de outros dados e informações, a realização de análises, estudos e avaliações para fins de tomada de decisões, definição de estratégias de atuação, assunção de compromissos e obrigações e quaisquer outras finalidades, em qualquer tempo e sob qualquer condição. É proibida a reprodução ou utilização total ou parcial do presente sem a identificação da fonte.

Tabela 4 – Limites considerados nesta semana operativa para intercâmbio de energia

Limites de Intercâmbio (MWmed)				
Fluxo	Patamar	14/02 a 20/02/2026		Demais Semanas
RNE	Pesada	11.000		11.000
	Média	11.000		11.000
	Leve	11.000		11.000
FNS	Pesada	3.200		3.200
	Média	3.200		3.200
	Leve	3.200		3.200
FNNE	Pesada	**6.150**	(A)	7.800
	Média	**5.552**		7.800
	Leve	**4.808**		7.800
EXPORT. NE	Pesada	14.700		14.700
	Média	14.700		14.700
	Leve	14.700		14.700
FMCCO	Pesada	5.000		5.000
	Média	5.000		5.000
	Leve	5.000		5.000
FSENE	Pesada	6.000		6.000
	Média	6.000		6.000
	Leve	6.000		6.000
FNS + FNESE	Pesada	7.488		7.488
	Média	6.504		6.504
	Leve	7.700		7.700
RSE	Pesada	6.020		6.020
	Média	6.020		6.020
	Leve	7.730		7.730
FORNEC. SUL	Pesada	7.000		7.000
	Média	7.000		7.000
	Leve	7.000		7.000

Limites de Intercâmbio (MWmed)				
Fluxo	Patamar	14/02 a 20/02/2026		Demais Semanas
RECEB. SUL	Pesada	10.800		10.800
	Média	7.150		7.150
	Leve	9.800		9.800
ELO CC 50 Hz	Pesada	3.132		3.132
	Média	3.132		3.132
	Leve	3.132		3.132
ITAIPU 60 Hz	Pesada	7.200		7.200
	Média	7.200		7.200
	Leve	7.200		7.200
EXP. N CA	Pesada	8.000		8.000
	Média	8.000		8.000
	Leve	8.000		8.000
FETXG + FTRXG	Pesada	4.200		4.200
	Média	4.200		4.200
	Leve	4.200		4.200
FXGET + FXGTR	Pesada	8.000		8.000
	Média	8.000		8.000
	Leve	8.000		8.000
FNESE	Pesada	5.300		5.300
	Média	4.375		4.375
	Leve	5.300		5.300
FNEN	Pesada	**5.400**	(A) (B) (C)	6.800
	Média	**5.377**		6.800
	Leve	**5.312**		6.800
Ger_MADEIRA	Pesada	7.415		7.415
	Média	7.411		7.411
	Leve	7.418		7.418

(A) SGI 80.715-25
(B) SGI 5.076-26
(C) SGI 4.334-26

O conteúdo desta publicação foi produzido pelo ONS com base em dados e informações de conhecimento público. É de responsabilidade exclusiva dos agentes e demais interessados a obtenção de outros dados e informações, a realização de análises, estudos e avaliações para fins de tomada de decisões, definição de estratégias de atuação, assunção de compromissos e obrigações e quaisquer outras finalidades, em qualquer tempo e sob qualquer condição. É proibida a reprodução ou utilização total ou parcial do presente sem a identificação da fonte.

3.3. Previsão de carga

A partir do fechamento da 2ª Revisão Semanal do PMO de Fevereiro, as projeções de carga indicam variações, em relação ao mesmo mês do ano anterior, de -7,5% no Subsistema Sudeste/Centro-Oeste, -2,9% no Sul, 3,5% no Nordeste e 5,8% no Norte.

Na semana operativa atual (07/02 a 13/02), a estimativa de fechamento da carga global do SIN aponta resultado 1,7% inferior ao da semana anterior (31/01 a 06/02), com expectativa de 85.727 MW médios. Esse comportamento está associado, sobretudo, ao efeito calendário, com início de impacto do Carnaval em algumas localidades, em um contexto de temperaturas relativamente estáveis na maior parte das capitais.

No Sudeste/Centro-Oeste, observa-se redução de 1,5% da carga em relação à semana anterior, compatível com o arrefecimento da atividade econômica associado ao período e com maior ocorrência de precipitação até meados da semana. No Sul, por sua vez, a carga registrou crescimento de 2,4% frente à semana anterior, com menor influência do efeito feriado nas capitais mais representativas do subsistema.

Nos subsistemas Norte e Nordeste, também se observou redução de carga na comparação semanal, com variações de -2,8% e -5,5%, respectivamente, indicando um processo de desaceleração das atividades devido à proximidade do feriado do carnaval.

Para a próxima semana operativa (14/02 a 20/02), projeta-se diminuição de 5,3% na carga do SIN em relação à semana atual, totalizando 81.215 MW médios. Esse recuo da carga está diretamente relacionado ao efeito do feriado. Do ponto de vista meteorológico, projeta-se redução das temperaturas máximas em capitais do Sul, como Porto Alegre (31 °C para 28 °C), Florianópolis (31 °C para 27 °C) e Curitiba (29 °C para 28 °C). No Sudeste/Centro-Oeste, as máximas devem permanecer próximas às atuais, com variações em Rio de Janeiro (34 °C para 36 °C), São Paulo (28 °C para 30 °C) e manutenção em Belo Horizonte (29 °C). No Norte e Nordeste, as temperaturas seguem com baixa oscilação, com Recife (30 °C para 31 °C), Salvador (33 °C para 32 °C), Belém (manutenção em 30 °C) e Manaus (31 °C para 32 °C), preservando o padrão típico do período.

Tabela 5 – Evolução da carga do PMO de Fevereiro de 2026

Subsistema	CARGA SEMANAL (MWmed)					CARGA MENSAL (MWmed)	
	1ª Sem	2ª Sem	3ª Sem	4ª Sem	5ª Sem	fev/26	Var. (%) fev/26 -> fev/25
SE/CO	47.829	46.967	44.508	49.703	50.200	47.336	-7,5%
Sul	16.497	16.902	15.569	16.370	16.011	16.317	-2,9%
Nordeste	14.533	13.756	13.154	14.235	14.482	13.918	3,5%
Norte	8.354	8.102	7.984	8.233	8.265	8.165	5,8%
SIN	**87.213**	**85.727**	**81.215**	**88.541**	**88.958**	**85.736**	**-3,8%**

O conteúdo desta publicação foi produzido pelo ONS com base em dados e informações de conhecimento público. É de responsabilidade exclusiva dos agentes e demais interessados a obtenção de outros dados e informações, a realização de análises, estudos e avaliações para fins de tomada de decisões, definição de estratégias de atuação, assunção de compromissos e obrigações e quaisquer outras finalidades, em qualquer tempo e sob qualquer condição. É proibida a reprodução ou utilização total ou parcial do presente sem a identificação da fonte.

3.4. Potência Hidráulica Total Disponível no SIN

O gráfico a seguir mostra a disponibilidade hidráulica total do SIN, para este mês, de acordo com o cronograma de manutenção informado pelos agentes para esta Revisão.

Figura 16 – Potência hidráulica disponível no SIN

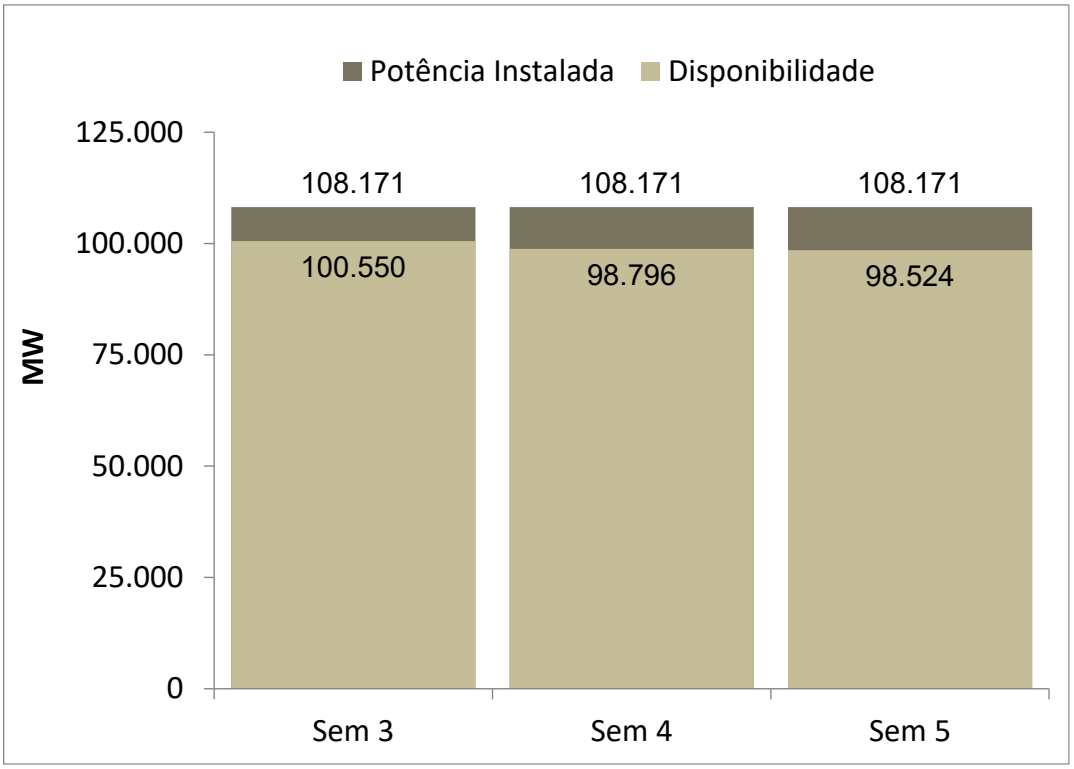

3.5. Armazenamentos Iniciais por Subsistema

Tabela 6 – Armazenamentos iniciais, por subsistema, considerados para esta semana operativa

Armazenamento (%EARmáx) - 0:00 h do dia 14/02/2026		
Subsistema	**Nível previsto na Revisão 1 do PMO Fev/2026**	**Partida informada pelos Agentes para a Revisão 2 do PMO Fev/2026**
SE/CO	53,1	53,6
S	50,6	48,4
NE	60,9	61,4
N	56,7	58,6

A primeira coluna da tabela acima corresponde ao armazenamento previsto na Revisão 1 do PMO de Fevereiro de 2026, para a 0:00 h do dia 14/02/2026. A segunda coluna apresenta os armazenamentos obtidos a partir dos níveis de partida informados pelos Agentes de Geração para seus aproveitamentos com reservatórios.

O conteúdo desta publicação foi produzido pelo ONS com base em dados e informações de conhecimento público. É de responsabilidade exclusiva dos agentes e demais interessados a obtenção de outros dados e informações, a realização de análises, estudos e avaliações para fins de tomada de decisões, definição de estratégias de atuação, assunção de compromissos e obrigações e quaisquer outras finalidades, em qualquer tempo e sob qualquer condição. É proibida a reprodução ou utilização total ou parcial do presente sem a identificação da fonte.

4. PRINCIPAIS RESULTADOS

4.1. Política de Operação Energética

Para esta semana operativa, está prevista a seguinte política de intercâmbio de energia entre regiões:

Região SE/CO:

- Utilização dos recursos das bacias dos rios Grande, Paranaíba e Paraná, conforme necessidade de alocação para o atendimento à ponta de carga e controle de nível dos reservatórios;

Região Sul:

- Geração dimensionada para controle de nível, controle de fluxos de intercâmbio (RSUL/FBTA) e atendimento da ponta de carga;

Região NE:

- Operação hidráulica modulando, quando necessário, para atendimento à ponta de carga do SIN, com controle para atendimento à máxima média mensal estabelecida pela ANA para operação na faixa de atenção do reservatório de Sobradinho;

Região Norte:

- Perfil exportador de energia em todos os patamares;

- Geração hidráulica dimensionada para controle de nível e atendimento a todos os patamares de carga.

4.2. Custo Marginal de Operação – CMO

A figura a seguir apresenta os Custos Marginais de Operação, em valores médios semanais, para as semanas operativas deste mês.

Figura 17 – CMO em valores médios

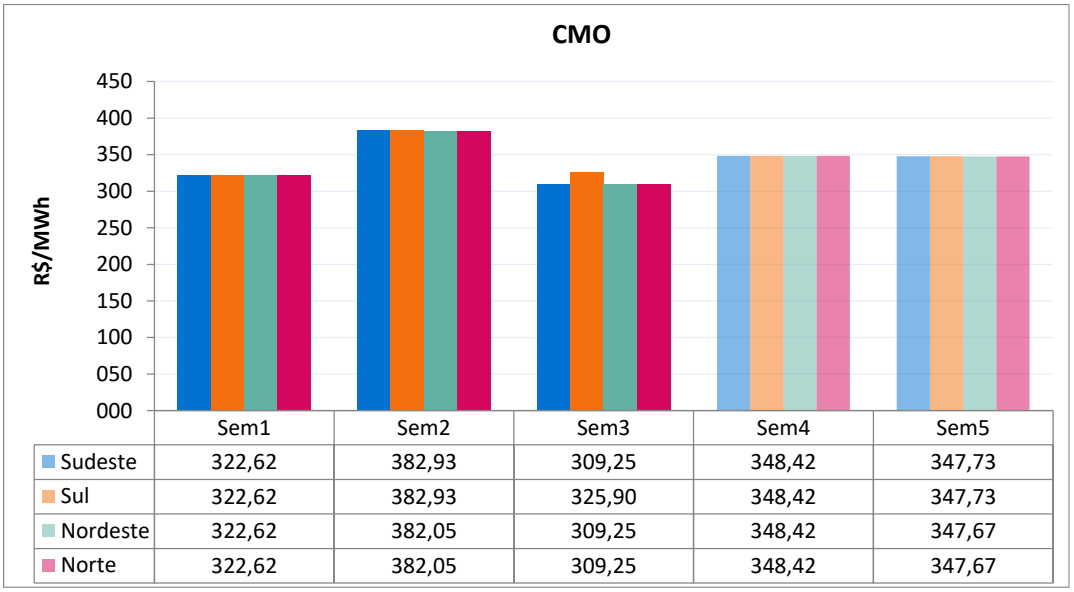

	Sem1	Sem2	Sem3	Sem4	Sem5
Sudeste	322,62	382,93	309,25	348,42	347,73
Sul	322,62	382,93	325,90	348,42	347,73
Nordeste	322,62	382,05	309,25	348,42	347,67
Norte	322,62	382,05	309,25	348,42	347,67

A tabela a seguir apresenta o custo marginal de operação, por subsistema e patamar de carga, para a próxima semana operativa.

O conteúdo desta publicação foi produzido pelo ONS com base em dados e informações de conhecimento público. É de responsabilidade exclusiva dos agentes e demais interessados a obtenção de outros dados e informações, a realização de análises, estudos e avaliações para fins de tomada de decisões, definição de estratégias de atuação, assunção de compromissos e obrigações e quaisquer outras finalidades, em qualquer tempo e sob qualquer condição. É proibida a reprodução ou utilização total ou parcial do presente sem a identificação da fonte.

Tabela 7 – CMO para esta semana operativa

Patamares de Carga	CMO (R$/MWh)			
	SE/CO	S	NE	N
Pesada	321,48	341,57	321,48	321,48
Média	308,16	341,73	308,16	308,16
Leve	306,33	306,33	306,33	306,33
Média Semanal	309,25	325,90	309,25	309,25

4.3. Energia Armazenada

O processo de otimização realizado pelo programa DECOMP indicou os armazenamentos mostrados na figura a seguir para as próximas semanas operativas do mês de fevereiro/2026.

Figura 18 – Energias Armazenadas nas semanas operativas do mês de fevereiro/2026

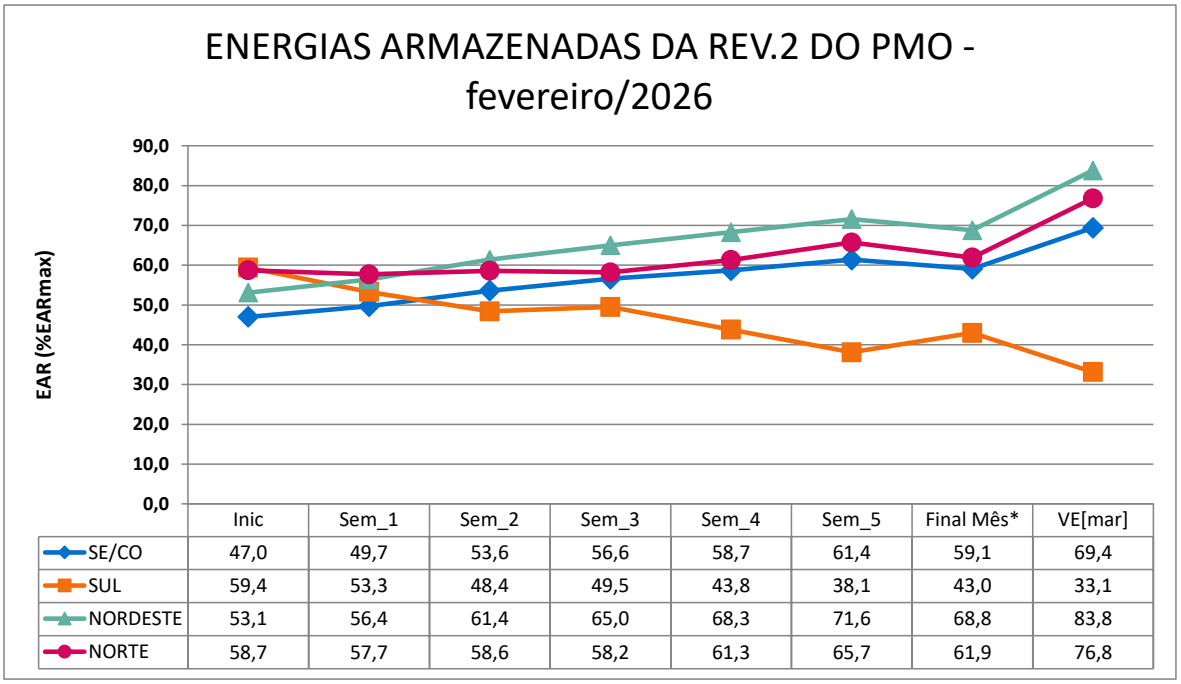

	Inic	Sem_1	Sem_2	Sem_3	Sem_4	Sem_5	Final Mês*	VE[mar]
SE/CO	47,0	49,7	53,6	56,6	58,7	61,4	59,1	69,4
SUL	59,4	53,3	48,4	49,5	43,8	38,1	43,0	33,1
NORDESTE	53,1	56,4	61,4	65,0	68,3	71,6	68,8	83,8
NORTE	58,7	57,7	58,6	58,2	61,3	65,7	61,9	76,8

Os armazenamentos da figura anterior estão expressos em percentual da Energia Armazenável Máxima de cada subsistema, que são mostradas na tabela a seguir.

Tabela 8 – Energia Armazenável Máxima por subsistema no PMO de Fevereiro/2026

ENERGIA ARMAZENÁVEL MÁXIMA (MWmed)		
Subsistema	fevereiro	março
SE/CO	205.569	205.569
S	20.458	20.458
NE	51.718	51.718
N	15.144	14.860

O conteúdo desta publicação foi produzido pelo ONS com base em dados e informações de conhecimento público. É de responsabilidade exclusiva dos agentes e demais interessados a obtenção de outros dados e informações, a realização de análises, estudos e avaliações para fins de tomada de decisões, definição de estratégias de atuação, assunção de compromissos e obrigações e quaisquer outras finalidades, em qualquer tempo e sob qualquer condição. É proibida a reprodução ou utilização total ou parcial do presente sem a identificação da fonte.

5. GERAÇÃO TÉRMICA

A Figura 19 apresenta, para cada subsistema do SIN, o despacho térmico por modalidade indicado pelo Decomp para esta semana operativa.

Figura 19 – Geração térmica para a próxima semana operativa

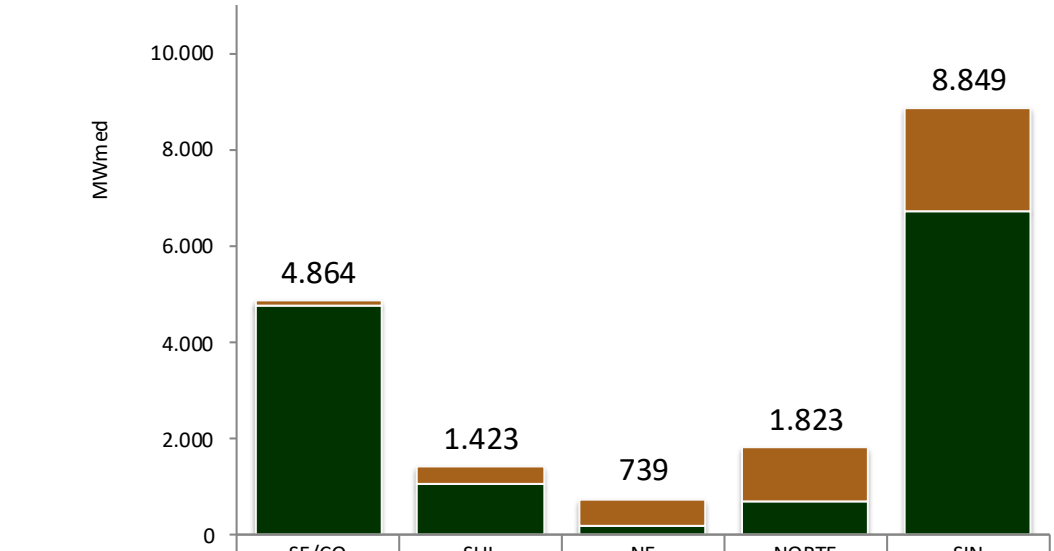

	SE/CO	SUL	NE	NORTE	SIN
TOTAL	4.864	1.423	739	1.823	8.849
ORDEM DE MÉRITO	120	353	551	1115	2139
RESTRIÇÃO ELÉTRICA	0	0	0	0	0
INFLEXIBILIDADE	4744	1070	188	708	6710

Na tabela abaixo segue a Indicação de despacho antecipado por ordem de mérito de custo para a semana de 18/04/2026 a 24/04/2026.

Tabela 9 – UTEs com contrato de combustível GNL

UTE			Benefício (R$/MWh)			Despacho antecipado por mérito		
Nome	Código	CVU (R$/MWh)	Carga Pesada	Carga Média	Carga Leve	Carga Pesada	Carga Média	Carga Leve
SANTA CRUZ	86	488,96	178,29	170,93	158,41	Não	Não	Não
PSERGIPE I	224	311,29	178,28	167,44	158,01	Não	Não	Não

Assim sendo, não há previsão de despacho antecipado por ordem de mérito de custo para as UTE Santa Cruz e Porto Sergipe I, para a semana de 18/04/2026 a 24/04/2026.

O conteúdo desta publicação foi produzido pelo ONS com base em dados e informações de conhecimento público. É de responsabilidade exclusiva dos agentes e demais interessados a obtenção de outros dados e informações, a realização de análises, estudos e avaliações para fins de tomada de decisões, definição de estratégias de atuação, assunção de compromissos e obrigações e quaisquer outras finalidades, em qualquer tempo e sob qualquer condição. É proibida a reprodução ou utilização total ou parcial do presente sem a identificação da fonte.

6. RESUMO DOS RESULTADOS DO PMO

As figuras a seguir apresentam um resumo dos resultados da Revisão 2 de Fevereiro/2026, com informações da Energia Natural Afluente (ENA), da Energia Armazenada (EAR) e do Custo Marginal de Operação (CMO) nos subsistemas do Sistema Interligado Nacional (SIN). São apresentados os valores semanais observados e previstos e o valor esperado dos cenários gerados para o mês de março/2026.

Figura 20 – Resumo de fevereiro/2026 para o Subsistema Sudeste/Centro-Oeste

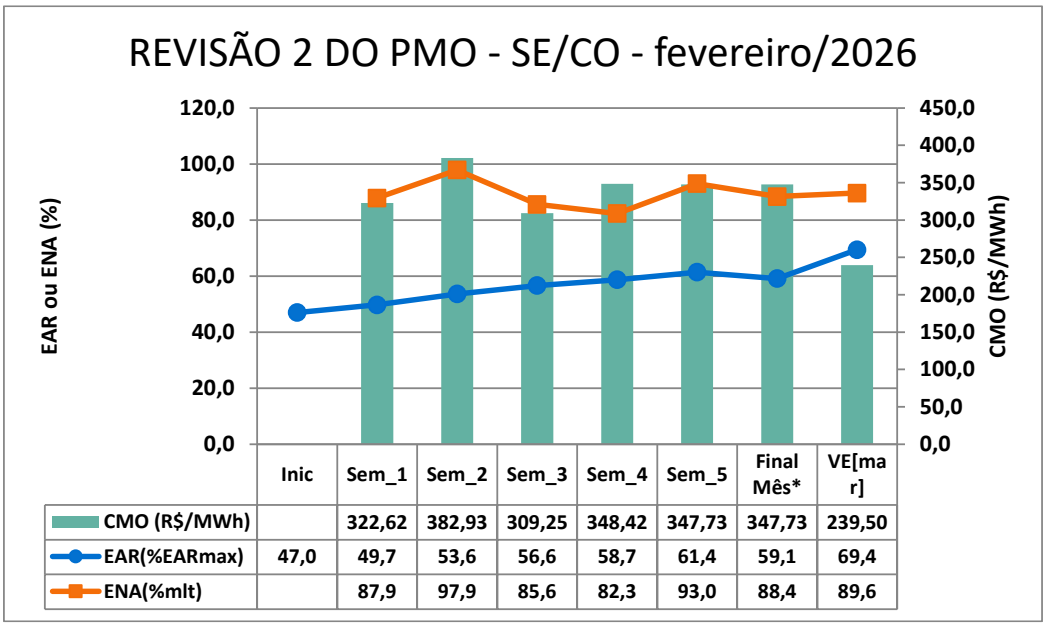

	Inic	Sem_1	Sem_2	Sem_3	Sem_4	Sem_5	Final Mês*	VE[mar]
CMO (R$/MWh)		322,62	382,93	309,25	348,42	347,73	347,73	239,50
EAR(%EARmax)	47,0	49,7	53,6	56,6	58,7	61,4	59,1	69,4
ENA(%mlt)		87,9	97,9	85,6	82,3	93,0	88,4	89,6

Figura 21 – Resumo de fevereiro/2026 para o Subsistema Sul

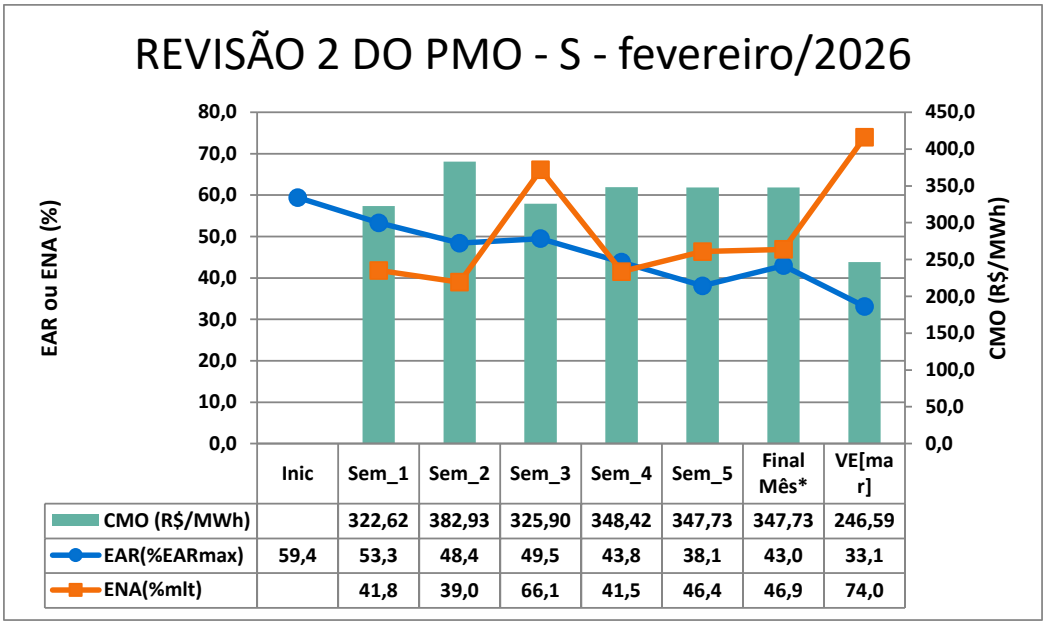

	Inic	Sem_1	Sem_2	Sem_3	Sem_4	Sem_5	Final Mês*	VE[mar]
CMO (R$/MWh)		322,62	382,93	325,90	348,42	347,73	347,73	246,59
EAR(%EARmax)	59,4	53,3	48,4	49,5	43,8	38,1	43,0	33,1
ENA(%mlt)		41,8	39,0	66,1	41,5	46,4	46,9	74,0

O conteúdo desta publicação foi produzido pelo ONS com base em dados e informações de conhecimento público. É de responsabilidade exclusiva dos agentes e demais interessados a obtenção de outros dados e informações, a realização de análises, estudos e avaliações para fins de tomada de decisões, definição de estratégias de atuação, assunção de compromissos e obrigações e quaisquer outras finalidades, em qualquer tempo e sob qualquer condição. É proibida a reprodução ou utilização total ou parcial do presente sem a identificação da fonte.

Figura 22 – Resumo de fevereiro/2026 para o Subsistema Nordeste

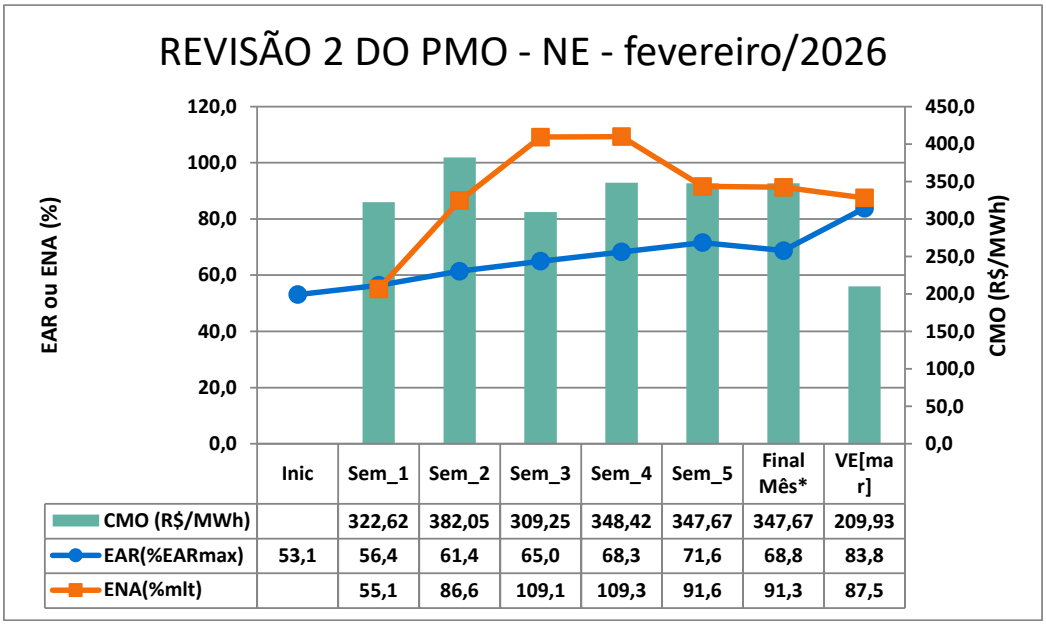

	Inic	Sem_1	Sem_2	Sem_3	Sem_4	Sem_5	Final Mês*	VE[mar]
CMO (R$/MWh)		322,62	382,05	309,25	348,42	347,67	347,67	209,93
EAR(%EARmax)	53,1	56,4	61,4	65,0	68,3	71,6	68,8	83,8
ENA(%mlt)		55,1	86,6	109,1	109,3	91,6	91,3	87,5

Figura 23 – Resumo de fevereiro/2026 para o Subsistema Norte

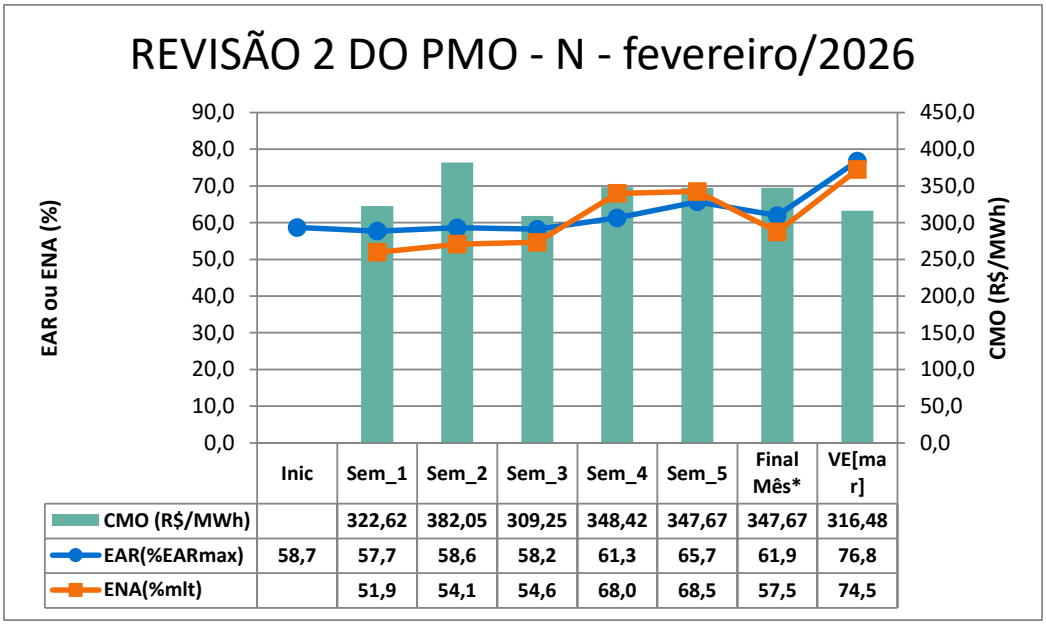

	Inic	Sem_1	Sem_2	Sem_3	Sem_4	Sem_5	Final Mês*	VE[mar]
CMO (R$/MWh)		322,62	382,05	309,25	348,42	347,67	347,67	316,48
EAR(%EARmax)	58,7	57,7	58,6	58,2	61,3	65,7	61,9	76,8
ENA(%mlt)		51,9	54,1	54,6	68,0	68,5	57,5	74,5

O conteúdo desta publicação foi produzido pelo ONS com base em dados e informações de conhecimento público. É de responsabilidade exclusiva dos agentes e demais interessados a obtenção de outros dados e informações, a realização de análises, estudos e avaliações para fins de tomada de decisões, definição de estratégias de atuação, assunção de compromissos e obrigações e quaisquer outras finalidades, em qualquer tempo e sob qualquer condição. É proibida a reprodução ou utilização total ou parcial do presente sem a identificação da fonte.

7. ARMAZENAMENTOS OPERATIVOS

Para uma melhor avaliação de diversos cenários hidrometeorológicos, notadamente, aqueles de curto prazo e suas influências nas previsões de vazões nos subsistemas, os resultados desta revisão do PMO contemplam cenários de afluências visando melhor representar a ocorrência de precipitação e, consequentemente, seus efeitos sobre as afluências e armazenamentos.

Apresentamos a seguir as correspondentes energias naturais afluentes e os resultados obtidos com a aplicação do cenário de afluência utilizado no estudo.

Tabela 10 – Previsão de ENA do caso de valor esperado das previsões de afluência

Subsistema	ENERGIAS NATURAIS AFLUENTES			
	Previsão Semanal		Previsão Mensal	
	(MWmed)	%MLT	(MWmed)	%MLT
SE/CO	60.638	86	62.630	88
Sul	5.455	66	3.869	47
Nordeste	15.482	109	12.946	91
Norte	12.489	55	13.078	58

Tabela 11 – Previsão de %EARmáx para o final do mês

Subsistema	% EARmáx 13/02	% EARmáx - 28/02
	NÍVEL INICIAL	NÍVEL PMO
SE/CO	53,6	59,1
Sul	48,4	43,0
Nordeste	61,4	68,8
Norte	58,6	61,9

O conteúdo desta publicação foi produzido pelo ONS com base em dados e informações de conhecimento público. É de responsabilidade exclusiva dos agentes e demais interessados a obtenção de outros dados e informações, a realização de análises, estudos e avaliações para fins de tomada de decisões, definição de estratégias de atuação, assunção de compromissos e obrigações e quaisquer outras finalidades, em qualquer tempo e sob qualquer condição. É proibida a reprodução ou utilização total ou parcial do presente sem a identificação da fonte.

8. RESERVATÓRIOS EQUIVALENTES DE ENERGIA

A seguir são apresentadas as previsões de Energia Natural Afluente para a próxima semana operativa e para o mês de fevereiro, bem como as previsões de Energia Armazenada nos Reservatórios Equivalentes de Energia – REE, desta revisão do PMO de Fevereiro de 2026.

Tabela 12 – Previsão de ENA por REE

Valor Esperado das Energias Naturais Afluentes				
REE	Previsão Semanal		Previsão Mensal	
	14/02/2026 a 20/02/2026		fev/26	
	(MWmed)	%MLT	(MWmed)	%MLT
Sudeste	5.856	55	7.438	70
Madeira	8.830	84	9.698	92
Teles Pires	5.267	131	4.618	115
Itaipu	2.888	73	2.125	53
Paraná	35.502	94	36.922	97
Paranapanema	2.290	61	1.824	48
Sul	3.358	86	2.119	54
Iguaçu	2.097	48	1.750	40
Nordeste	15.481	109	12.946	91
Norte	6.430	50	6.906	54
Belo Monte	5.118	56	5.339	58
Manaus	881	103	803	94

Tabela 13 – Previsão de %EARmáx por REE

% Energia Armazenável Máxima		
REE	Previsão Semanal	Previsão Mensal
	20-fev	28-fev
	(%EARmáx)	(%EARmáx)
Sudeste	57,3	58,2
Madeira	74,7	72,3
Teles Pires	42,1	57,9
Itaipu	62,8	91,4
Paraná	56,5	60,0
Paranapanema	55,1	50,1
Sul	59,2	51,1
Iguaçu	40,0	35,0
Nordeste	65,0	68,8
Norte	59,2	63,2
Belo Monte	26,6	50,6
Manaus	42,2	39,8

O conteúdo desta publicação foi produzido pelo ONS com base em dados e informações de conhecimento público. É de responsabilidade exclusiva dos agentes e demais interessados a obtenção de outros dados e informações, a realização de análises, estudos e avaliações para fins de tomada de decisões, definição de estratégias de atuação, assunção de compromissos e obrigações e quaisquer outras finalidades, em qualquer tempo e sob qualquer condição. É proibida a reprodução ou utilização total ou parcial do presente sem a identificação da fonte.

9. DESPACHO TÉRMICO POR MODALIDADE, PATAMAR DE CARGA E USINA

Nas tabelas abaixo, a diferenciação entre geração por inflexibilidade e por ordem de mérito tem caráter informativo, com o objetivo de detalhar a informação de inflexibilidade enviada pelos respectivos agentes para esta revisão do PMO. Ressalta-se que nas etapas de Programação Diária e Tempo Real, o montante despachado nas usinas termelétricas indicadas por ordem de mérito é plenamente intitulado como ordem de mérito.

REGIÃO SUDESTE/CENTRO-OESTE

Térmicas Potência (MW)	Combustível	CVU (R$/MWh)	Inflexibilidade			Ordem de Mérito			Total Mérito e INFL.			Razão Elétrica			Total UTE		
			P	M	L	P	M	L	P	M	L	P	M	L	P	M	L
ATLANTICO (490)	Resíduos	0,00	338,4	338,4	338,4				338,4	338,4	338,4				338,4	338,4	338,4
DAIA (44)	Diesel	---															
PALMEIR_GO (176)	Diesel	---															
PAULINIA (16)	Gás	---															
TNORTE 2 (349)	Óleo	---															
W.ARJONA O (177)	Diesel	---															
XAVANTES (54)	Diesel	---															
ANGRA 2 (1350)	Nuclear	20,12				0,0	0,0	0,0									
ANGRA 1 (640)	Nuclear	31,17	640,0	640,0	640,0	0,0	0,0	0,0	640,0	640,0	640,0				640,0	640,0	640,0
M.AZUL (566)	Gás	133,71	495,0	495,0	495,0	70,5	70,5	70,5	565,5	565,5	565,5				565,5	565,5	565,5
O.PINTADA (50)	Biomassa	152,33				50,0	50,0	50,0	50,0	50,0	50,0				50,0	50,0	50,0
UTE STA VI (41)	Biomassa	164,56				0,0	0,0	0,0									
ST.CRUZ 34 (436)	Óleo	310,41															
CUBATAO (216)	Gás	356,45	205,0	205,0	205,0				205,0	205,0	205,0				205,0	205,0	205,0
UTE GNA II (1673)	Gás	464,08															
BAIXADA FL (530)	Gás	482,92	520,0	520,0	520,0				520,0	520,0	520,0				520,0	520,0	520,0
SANTA CRUZ (500)	GNL	488,96															
KARKEY 013 (259)	Gás	730,80	31,0	31,0	31,0				31,0	31,0	31,0				31,0	31,0	31,0
KARKEY 019 (116)	Gás	730,80															
T.LAGOAS (350)	Gás	825,23	180,0	180,0	180,0				180,0	180,0	180,0				180,0	180,0	180,0
CUIABA CC (529)	Gás	859,98															
PORSUD I (116)	Gás	862,73															
PORSUD II (78)	Gás	864,22															
W.ARJONA (177)	Gás	874,61															
IBIRITE (226)	Gás	874,88	226,0	226,0	226,0				226,0	226,0	226,0				226,0	226,0	226,0
TERMORIO (989)	Gás	876,22	610,0	610,0	610,0				610,0	610,0	610,0				610,0	610,0	610,0
LUIZORMELO (204)	Gás	941,79															
UTE GNA I (1338)	Gás	956,16															
NORTEFLU (826)	Gás	966,92															
POVOACAO I (75)	Gás	986,05															
VIANA (175)	Óleo	990,61															
T.MACAE (922)	Gás	1066,66	675,0	675,0	675,0				675,0	675,0	675,0				675,0	675,0	675,0
VIANA I (37)	Gás	1124,32															
SEROPEDICA (360)	Gás	1136,90	360,0	360,0	360,0				360,0	360,0	360,0				360,0	360,0	360,0
J.FORA (87)	Gás	1146,82	84,0	84,0	84,0				84,0	84,0	84,0				84,0	84,0	84,0
NPIRATINGA (572)	Gás	1379,23	380,0	380,0	380,0				380,0	380,0	380,0				380,0	380,0	380,0
TOTAL SE/CO (14744)			4744,4	4744,4	4744,4	120,5	120,5	120,5	4864,9	4864,9	4864,9	0,0	0,0	0,0	4864,9	4864,9	4864,9

REGIÃO SUL

Térmicas Potência (MW)	Combustível	CVU (R$/MWh)	Inflexibilidade			Ordem de Mérito			Total Mérito e INFL.			Razão Elétrica			Total UTE		
			P	M	L	P	M	L	P	M	L	P	M	L	P	M	L
B.BONITA I (10)	Gás	---															
PAMPA SUL (345)	Carvão	105,94				345,0	345,0	345,0	345,0	345,0	345,0				345,0	345,0	345,0
SAO SEPE (8)	Biomassa	118,84				8,0	8,0	8,0	8,0	8,0	8,0				8,0	8,0	8,0
J.LACER. C (330)	Carvão	347,20	330,0	330,0	330,0				330,0	330,0	330,0				330,0	330,0	330,0
J.LACER. B (220)	Carvão	406,71	220,0	220,0	220,0				220,0	220,0	220,0				220,0	220,0	220,0
J.LAC. A2 (110)	Carvão	416,39	110,0	110,0	110,0				110,0	110,0	110,0				110,0	110,0	110,0
J.LAC. A1 (80)	Carvão	518,90	80,0	80,0	80,0				80,0	80,0	80,0				80,0	80,0	80,0
CANDIOTA_3 (350)	Carvão	519,16	330,0	330,0	330,0				330,0	330,0	330,0				330,0	330,0	330,0
ARAUCARIA (484)	Gás	900,00															
URUGUAIANA (640)	Gás	1268,92															
CANOAS (249)	Gás	1374,17															
TOTAL SUL (2826)			1070,0	1070,0	1070,0	353,0	353,0	353,0	1423,0	1423,0	1423,0	0,0	0,0	0,0	1423,0	1423,0	1423,0

O conteúdo desta publicação foi produzido pelo ONS com base em dados e informações de conhecimento público. É de responsabilidade exclusiva dos agentes e demais interessados a obtenção de outros dados e informações, a realização de análises, estudos e avaliações para fins de tomada de decisões, definição de estratégias de atuação, assunção de compromissos e obrigações e quaisquer outras finalidades, em qualquer tempo e sob qualquer condição. É proibida a reprodução ou utilização total ou parcial do presente sem a identificação da fonte.

REGIÃO NORDESTE

Térmicas Potência (MW)	Combustível	CVU (R$/MWh)	Inflexibilidade			Ordem de Mérito			Total Mérito e INFL.			Razão Elétrica			Total UTE		
			P	M	L	P	M	L	P	M	L	P	M	L	P	M	L
MARACANAU (168)	Óleo	---															
PETROLINA (136)	Óleo	---															
ERB CANDEI (17)	Biomassa	118,93				12,0	12,0	12,0	12,0	12,0	12,0				12,0	12,0	12,0
PROSP_I (28)	Gás	224,31				18,7	18,7	18,7	18,7	18,7	18,7				18,7	18,7	18,7
PROSP_III (56)	Gás	228,55				50,4	49,7	48,4	50,4	49,7	48,4				50,4	49,7	48,4
PROSP_II (37)	Gás	280,49				29,9	29,5	28,9	29,9	29,5	28,9				29,9	29,5	28,9
P.PECEM1 (720)	Carvão	308,16				720,0	697,2		720,0	697,2					720,0	697,2	0,0
PSERGIPE I (1593)	GNL	311,29															
P.PECEM2 (365)	Carvão	318,91				365,0			365,0						365,0	0,0	0,0
VALE ACU (110)	Gás	450,86	27,5	28,7	30,8				27,5	28,7	30,8				27,5	28,7	30,8
PERNAMBU_3 (201)	Óleo	753,06															
TERMOPE (550)	Gás	826,55															
SUAPE II (381)	Óleo	890,08															
T.BAHIA (186)	Gás	1024,43	158,9	158,9	158,9				158,9	158,9	158,9				158,9	158,9	158,9
GLOBAL I (136)	Óleo	1120,77															
GLOBAL II (136)	Óleo	1120,77															
TERMOCABO (50)	Óleo	1495,67															
TERMONE (171)	Óleo	1831,39															
TERMOPB (171)	Óleo	1831,39															
POTIGUAR (53)	Diesel	1841,86															
POTIGUAR_3 (66)	Diesel	1841,86															
CAMPINA_GR (169)	Óleo	2076,29															
TERMOCEARA (223)	Óleo	2244,40															
C.MURICY 2 (144)	Óleo	2301,01															
PECEM 2 (144)	Óleo	2324,95															
TOTAL NE (5725)			186,4	187,6	189,7	1196,0	807,1	108,0	1382,4	994,7	297,7	0,0	0,0	0,0	1382,4	994,7	297,7

REGIÃO NORTE

Térmicas Potência (MW)	Combustível	CVU (R$/MWh)	Inflexibilidade			Ordem de Mérito			Total Mérito e INFL.			Razão Elétrica			Total UTE		
			P	M	L	P	M	L	P	M	L	P	M	L	P	M	L
MARANHAO3 (519)	Gás	116,10				499,6	507,1	508,0	499,6	507,1	508,0				499,6	507,1	508,0
APARECIDA (166)	Gás	213,34	90,0	90,0	90,0	27,0	27,0	27,0	117,0	117,0	117,0				117,0	117,0	117,0
JARAQUI (75)	Gás	213,34	49,3	49,3	49,3	13,7	13,7	13,7	63,0	63,0	63,0				63,0	63,0	63,0
PIRARUCU (73)	Gás	213,34	66,0	66,0	66,0	1,0	1,0	1,0	67,0	67,0	67,0				67,0	67,0	67,0
PORAQUE (85)	Gás	213,34	49,5	49,5	49,5	18,5	18,5	18,5	68,0	68,0	68,0				68,0	68,0	68,0
TAMBAQUI (93)	Gás	213,34	56,0	56,0	56,0	7,0	7,0	7,0	63,0	63,0	63,0				63,0	63,0	63,0
TUCUNARE (73)	Gás	213,34	66,0	66,0	66,0	0,0	0,0	0,0	66,0	66,0	66,0				66,0	66,0	66,0
UTE MAUA 3 (591)	Gás	213,34	264,0	264,0	264,0	326,8	326,8	326,8	590,8	590,8	590,8				590,8	590,8	590,8
PARNAIBA_V (386)	Vapor	226,34				0,0	0,0	0,0									
JAGUATI II (141)	Gás	289,25				126,2	126,2	126,2	126,2	126,2	126,2				126,2	126,2	126,2
N.VENECIA2 (270)	Gás	308,35				259,9			259,9						259,9	0,0	0,0
P. ITAQUI (360)	Carvão	310,78				360,1			360,1						360,1	0,0	0,0
MARANHAO V (338)	Gás	446,77															
MARANHAOIV (338)	Gás	446,77															
BONFIM (12)	Biomassa	555,69	5,0	5,0	5,0				5,0	5,0	5,0				5,0	5,0	5,0
CANTA (12)	Biomassa	555,69	5,0	5,0	5,0				5,0	5,0	5,0				5,0	5,0	5,0
PAU RAINHA (12)	Biomassa	555,69	5,0	5,0	5,0				5,0	5,0	5,0				5,0	5,0	5,0
SANTA LUZ (12)	Biomassa	555,69	5,0	5,0	5,0				5,0	5,0	5,0				5,0	5,0	5,0
PARNAIB_IV (56)	Gás	788,17	56,0	46,0	35,0				56,0	46,0	35,0				56,0	46,0	35,0
BBF BALIZA (18)	Biomassa	876,44	5,0	5,0	5,0				5,0	5,0	5,0				5,0	5,0	5,0
GERAMAR1 (166)	Óleo	913,46															
GERAMAR2 (166)	Óleo	913,46															
M.C.SUCUBA (42)	Diesel	1738,08															
PALMAPLAN (12)	Biomassa	1864,46															
TOTAL NORTE (4303)			721,8	711,8	700,8	1639,8	1027,3	1028,2	2361,6	1739,1	1729,0	0,0	0,0	0,0	2361,6	1739,1	1729,0

O conteúdo desta publicação foi produzido pelo ONS com base em dados e informações de conhecimento público. É de responsabilidade exclusiva dos agentes e demais interessados a obtenção de outros dados e informações, a realização de análises, estudos e avaliações para fins de tomada de decisões, definição de estratégias de atuação, assunção de compromissos e obrigações e quaisquer outras finalidades, em qualquer tempo e sob qualquer condição. É proibida a reprodução ou utilização total ou parcial do presente sem a identificação da fonte.