1. APRESENTAÇÃO

Na semana de 07/06 a 13/06/2025 houve precipitação nas bacias dos rios Iguaçu, Paranapanema e na incremental a UHE Itaipu.

Na semana de 14/06 a 20/06/2025 deve ocorrer precipitação nas bacias dos rios Uruguai, Jacuí, Taquari-Antas, Iguaçu, Incremental a UHE Itaipu e em pontos isolados do Paranapanema. Há previsão de pancadas de chuva isolada para a bacia do rio Madeira, com os maiores totais de precipitação previstos para os trechos boliviano e peruano.

Os valores médios semanais do Custo Marginal de Operação – CMO dos subsistemas do SIN sofreram as seguintes alterações em relação à semana anterior:

- SE/CO: de R$ 273,73/MWh para R$ 273,50/MWh
- Sul: de R$ 273,73/MWh para R$ 273,50/MWh
- Nordeste: de R$ 273,73/MWh para R$ 273,47/MWh
- Norte: de R$ 273,73/MWh para R$ 273,50/MWh

Desde o dia 01/01/2020, o despacho por ordem de mérito é indicado diariamente pelos resultados do modelo DESSEM. Assim, o despacho por ordem de mérito semanal, conforme publicado nesse documento, tem caráter apenas informativo. Da mesma forma, desde o dia 01/01/2021, a formação de preço deixou o formato semanal/patamar de carga e passou a ser horário, de acordo também com os resultados do modelo DESSEM.

2. NOTÍCIAS

Nos dias 26 e 27 de junho será realizada a reunião de elaboração do PMO de Julho de 2025, em formato híbrido, presencialmente no auditório do Rio de Janeiro (com inscrição obrigatória para participação presencial) e com transmissão ao vivo através do site do ONS.

3. INFORMAÇÕES CONJUNTURAIS PARA ELABORAÇÃO DO PMO

3.1. Informações hidrometeorológicas

3.1.1. Condições antecedentes

A atuação de áreas de instabilidade e a formação de uma frente fria na Região Sul provocaram precipitação nas bacias dos rios Iguaçu, Paranapanema e na incremental a UHE Itaipu no início da semana. Em relação as demais bacias hidrográficas de interesse do SIN, não houve precipitação significativa.

O conteúdo desta publicação foi produzido pelo ONS com base em dados e informações de conhecimento público. É de responsabilidade exclusiva dos agentes e demais interessados a obtenção de outros dados e informações, a realização de análises, estudos e avaliações para fins de tomada de decisões, definição de estratégias de atuação, assunção de compromissos e obrigações e quaisquer outras finalidades, em qualquer tempo e sob qualquer condição. É proibida a reprodução ou utilização total ou parcial do presente sem a identificação da fonte.

Figura 1 – Precipitação observada (mm) no período de 07/06 a 13/06/2025

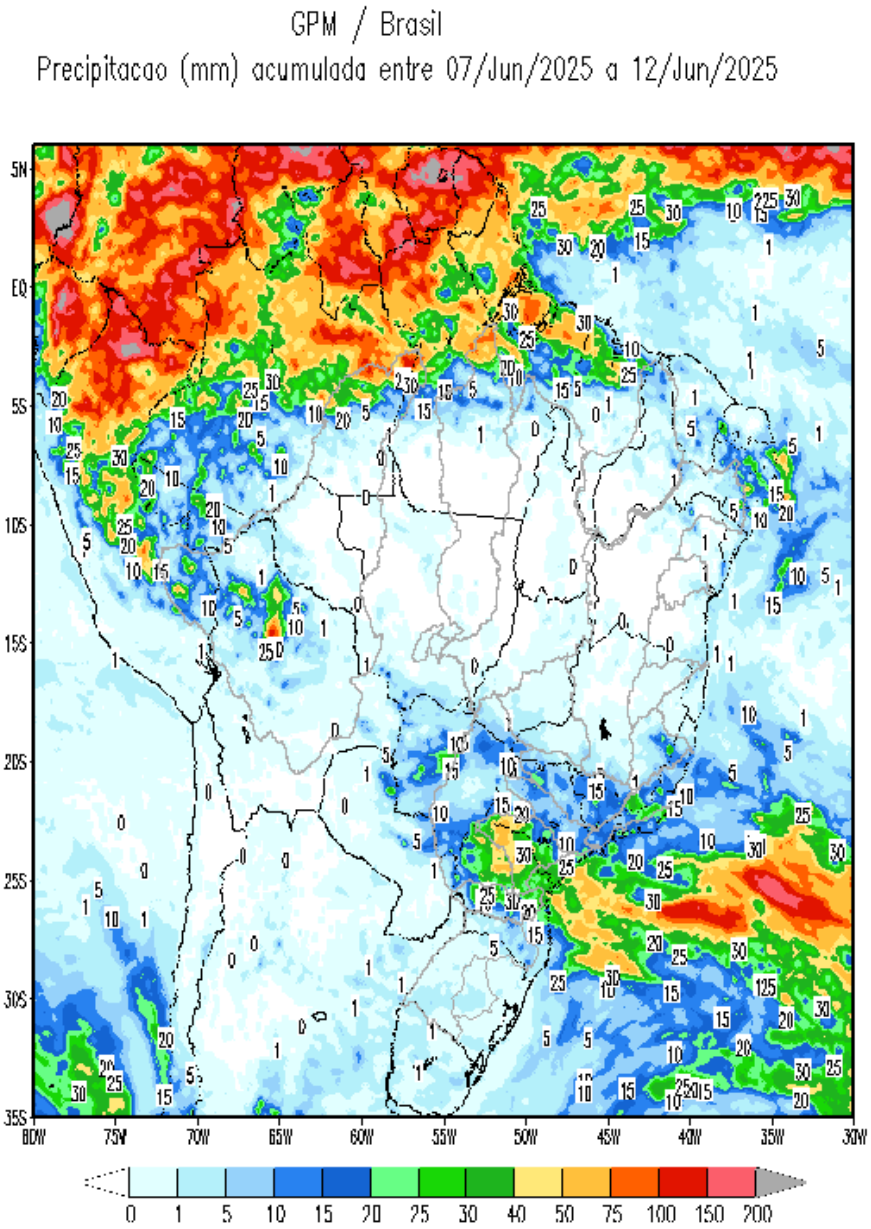

A Tabela 1 apresenta as energias naturais afluentes das semanas recentes. São apresentados os valores verificados na semana 31/05/2025 a 06/06/2025 e os estimados para fechamento da semana de 07/06/2025 a 13/06/2025.

Tabela 1 – Tendência hidrológica da ENA da Revisão 2 de Junho/2025

Revisão 2 do PMO de Junho/2025 - ENAs				
Subsistema	31/05 a 06/06/2025		07/06 a 13/06/2025	
	MWmed	%MLT	MWmed	%MLT
SE/CO	27.111	81	29.100	89
S	6.741	66	9.506	90
NE	2.133	44	1.818	40
N	8.410	70	7.186	67

O conteúdo desta publicação foi produzido pelo ONS com base em dados e informações de conhecimento público. É de responsabilidade exclusiva dos agentes e demais interessados a obtenção de outros dados e informações, a realização de análises, estudos e avaliações para fins de tomada de decisões, definição de estratégias de atuação, assunção de compromissos e obrigações e quaisquer outras finalidades, em qualquer tempo e sob qualquer condição. É proibida a reprodução ou utilização total ou parcial do presente sem a identificação da fonte.

3.1.2. Previsão para a próxima semana

A atuação de sistemas de baixa pressão na Região Sul e a passagem de uma frente fria pelo litoral da região ocasionam precipitação nas bacias dos rios Uruguai, Jacuí, Taquari-Antas, Iguaçu, Incremental a UHE Itaipu e em pontos isolados do Paranapanema (Figura 2). Há previsão de pancadas de chuva isolada para a bacia do rio Madeira, com os maiores totais de precipitação previstos para os trechos boliviano e peruano. Para as demais bacias hidrográficas de interesse do SIN, não há previsão de precipitação significativa, condição típica desta época do ano.

Figura 2 - Precipitação acumulada prevista pelo modelo ECMWF - período de 14 a 20/06/2025

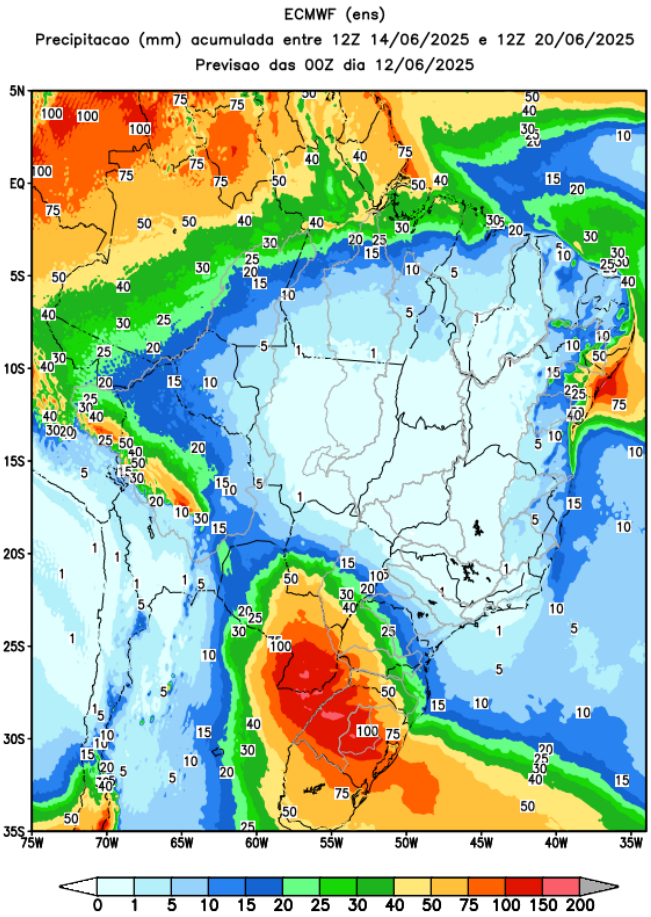

Em comparação com os valores estimados para a semana em curso, prevê-se para a próxima semana operativa ascensão nas afluências do subsistema Sul e recessão nas afluências dos subsistemas Sudeste/Centro-Oeste, Nordeste e Norte. A previsão mensal para junho indica a ocorrência de afluências abaixo da média histórica para todos os subsistemas.

Tabela 2 – Previsão de ENAs da Revisão 2 de Junho/2025

Revisão 2 do PMO de Junho/2025 - ENAs previstas				
Subsistema	14/06 a 20/06/2025		Mês de junho	
	MWmed	%MLT	MWmed	%MLT
SE/CO	26.147	80	26.148	80
S	10.193	96	9.506	90
NE	1.711	38	1.760	39
N	6.166	58	6.452	60

O conteúdo desta publicação foi produzido pelo ONS com base em dados e informações de conhecimento público. É de responsabilidade exclusiva dos agentes e demais interessados a obtenção de outros dados e informações, a realização de análises, estudos e avaliações para fins de tomada de decisões, definição de estratégias de atuação, assunção de compromissos e obrigações e quaisquer outras finalidades, em qualquer tempo e sob qualquer condição. É proibida a reprodução ou utilização total ou parcial do presente sem a identificação da fonte.

As figuras a seguir ilustram as ENAs semanais verificadas e previstas para as Revisões 1 e 2 do PMO de Junho/2025.

Figura 3 - Energias Naturais Afluentes ao Subsistema Sudeste/Centro-Oeste das Revisões 1 e 2 do PMO de Junho/2025

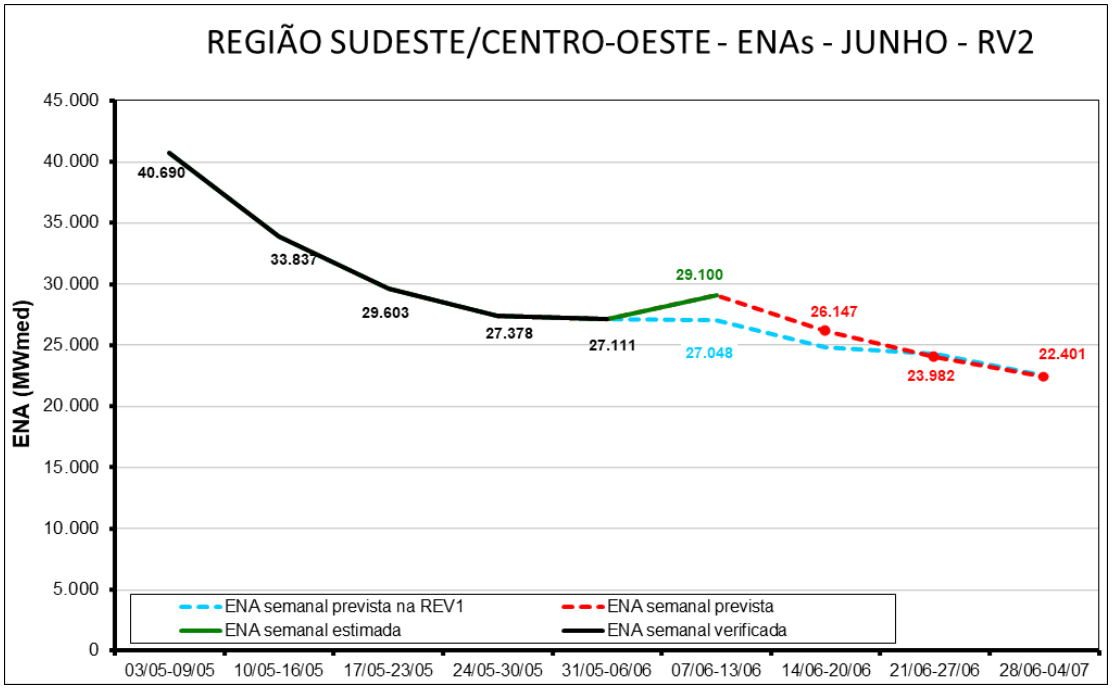

Figura 4 - Energias Naturais Afluentes ao Subsistema Sul das Revisões 1 e 2 do PMO de Junho/2025

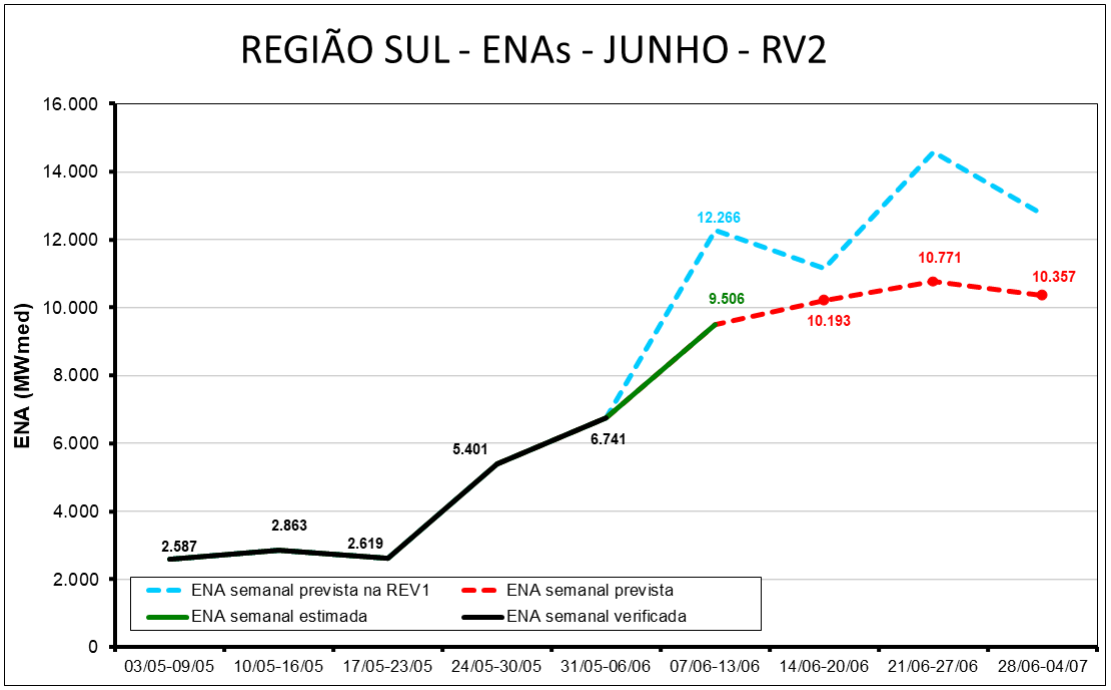

O conteúdo desta publicação foi produzido pelo ONS com base em dados e informações de conhecimento público. É de responsabilidade exclusiva dos agentes e demais interessados a obtenção de outros dados e informações, a realização de análises, estudos e avaliações para fins de tomada de decisões, definição de estratégias de atuação, assunção de compromissos e obrigações e quaisquer outras finalidades, em qualquer tempo e sob qualquer condição. É proibida a reprodução ou utilização total ou parcial do presente sem a identificação da fonte.

Figura 5 - Energias Naturais Afluentes ao Subsistema Nordeste das Revisões 1 e 2 do PMO de Junho/2025

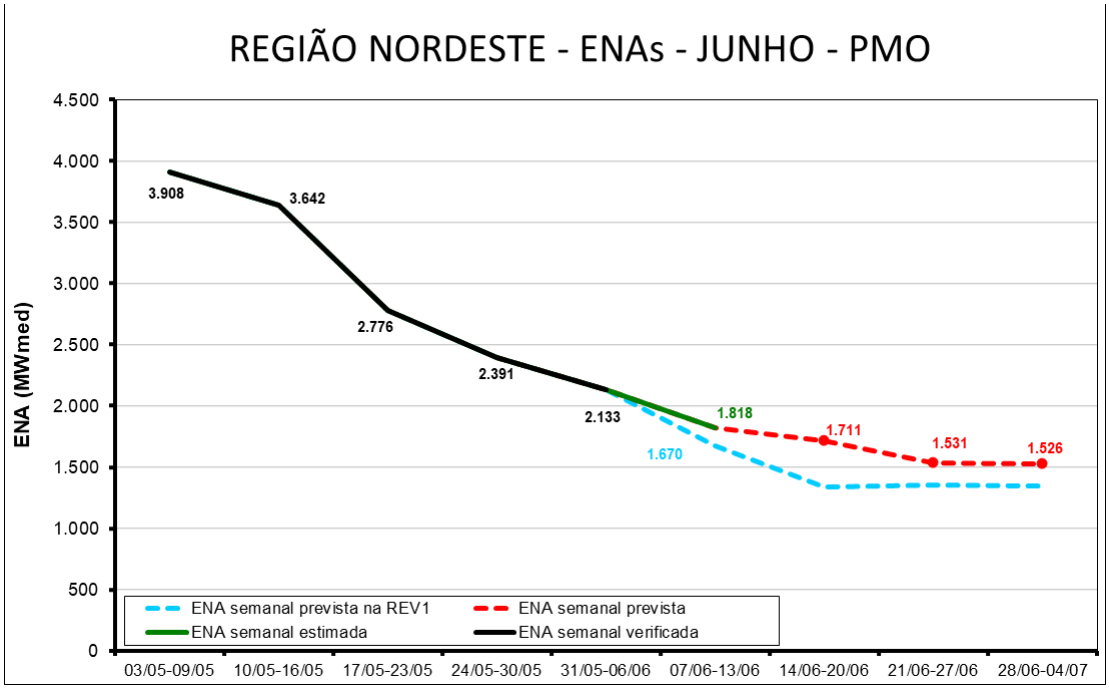

Figura 6 - Energias Naturais Afluentes ao Subsistema Norte das Revisões 1 e 2 do PMO de Junho/2025

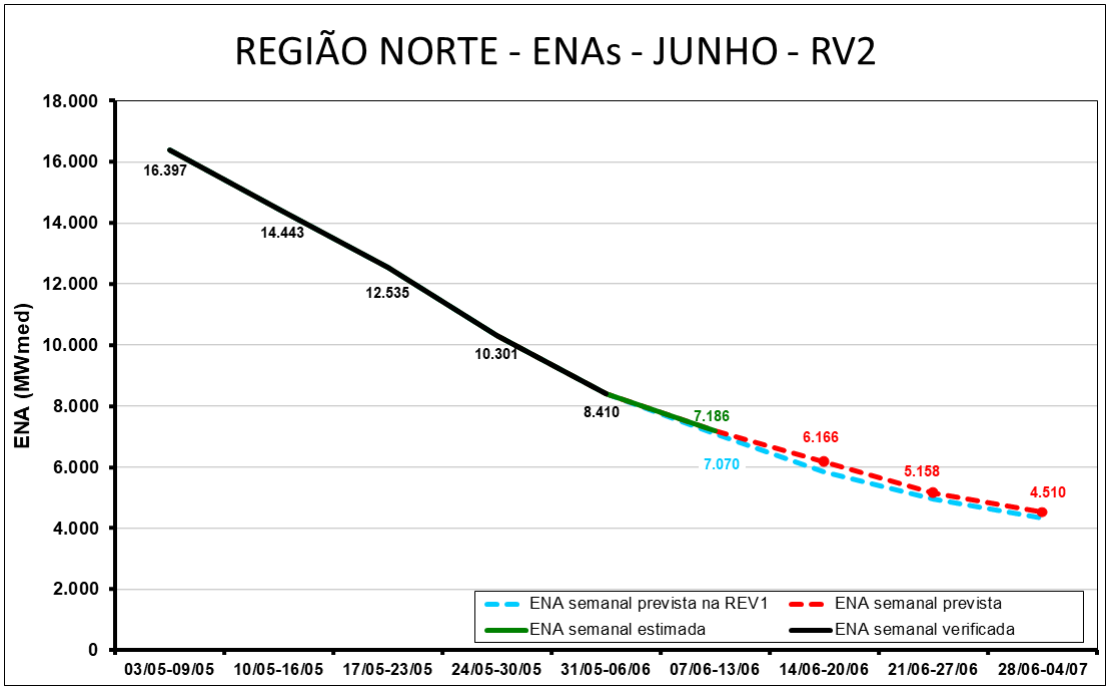

O conteúdo desta publicação foi produzido pelo ONS com base em dados e informações de conhecimento público. É de responsabilidade exclusiva dos agentes e demais interessados a obtenção de outros dados e informações, a realização de análises, estudos e avaliações para fins de tomada de decisões, definição de estratégias de atuação, assunção de compromissos e obrigações e quaisquer outras finalidades, em qualquer tempo e sob qualquer condição. É proibida a reprodução ou utilização total ou parcial do presente sem a identificação da fonte.

3.1.3. Cenários de ENAs para a Revisão 2 de Junho/2025

As figuras a seguir apresentam as características dos cenários de energias naturais afluentes gerados na Revisão 2 de Junho/2025, para acoplamento com a FCF do mês de julho/2025. São mostradas, para os quatro subsistemas, as amplitudes e as Funções de Distribuição Acumulada dos cenários de ENA, comparativamente com os valores considerados para as revisões anteriores do PMO de Junho/2025.

Figura 7 - Amplitude dos Cenários de ENA para o Subsistema Sudeste/Centro-Oeste, em %MLT, para a Revisão 2 de Junho/2025

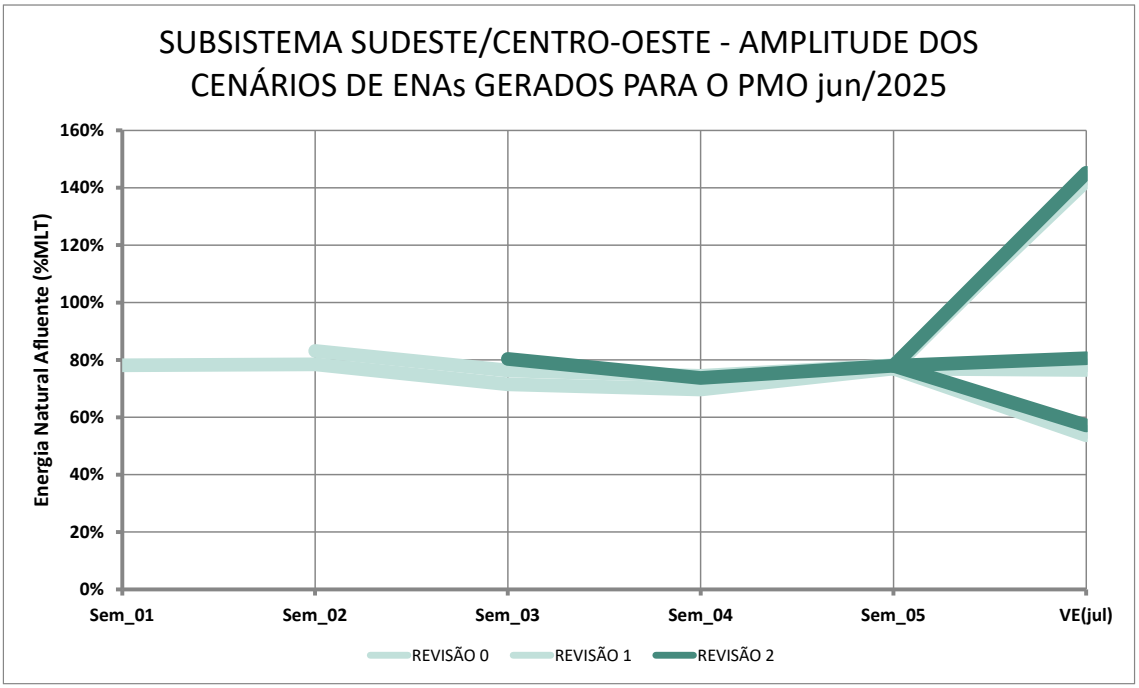

Figura 8 - Função de Distribuição Acumulada dos Cenários para o Subsistema Sudeste/Centro-Oeste para a Revisão 2 de Junho/2025

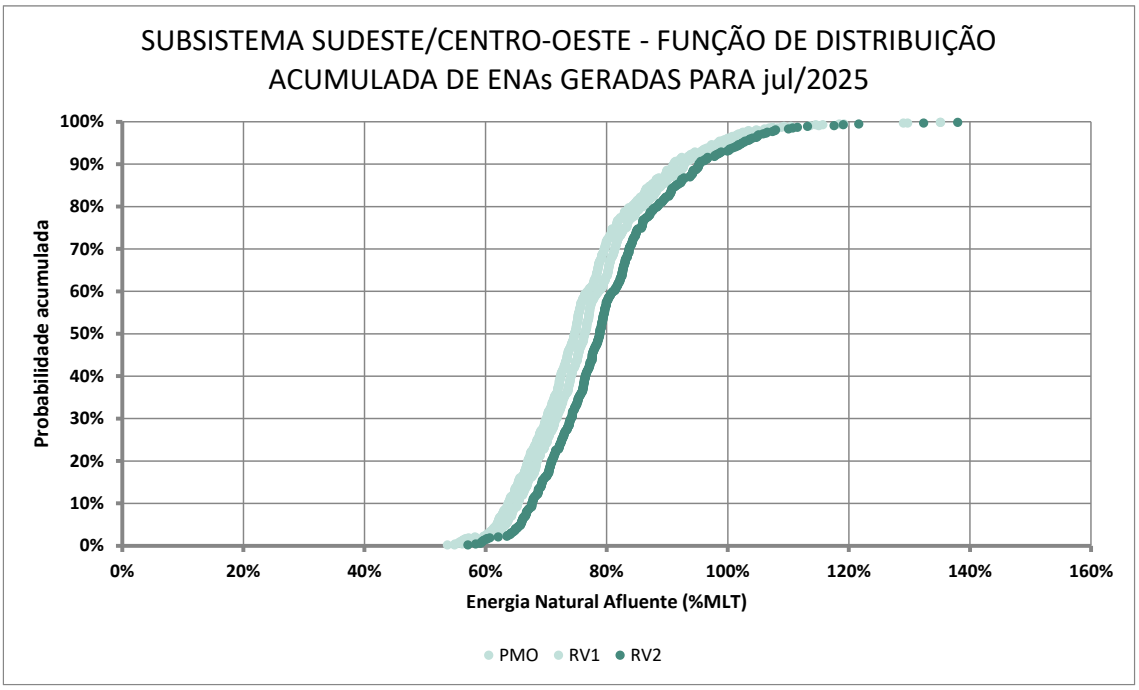

O conteúdo desta publicação foi produzido pelo ONS com base em dados e informações de conhecimento público. É de responsabilidade exclusiva dos agentes e demais interessados a obtenção de outros dados e informações, a realização de análises, estudos e avaliações para fins de tomada de decisões, definição de estratégias de atuação, assunção de compromissos e obrigações e quaisquer outras finalidades, em qualquer tempo e sob qualquer condição. É proibida a reprodução ou utilização total ou parcial do presente sem a identificação da fonte.

Figura 9 - Amplitude dos Cenários de ENA para o Subsistema Sul, em %MLT, para a Revisão 2 de Junho/2025

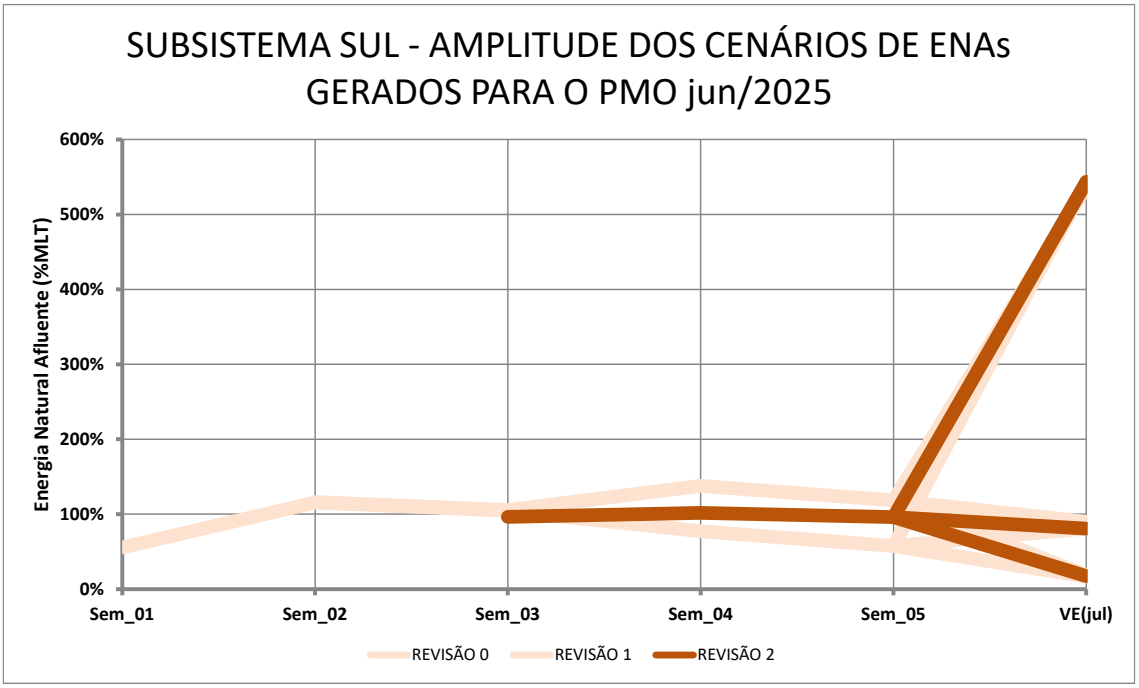

Figura 10 - Função de Distribuição Acumulada dos Cenários para o Subsistema Sul para a Revisão 2 de Junho/2025

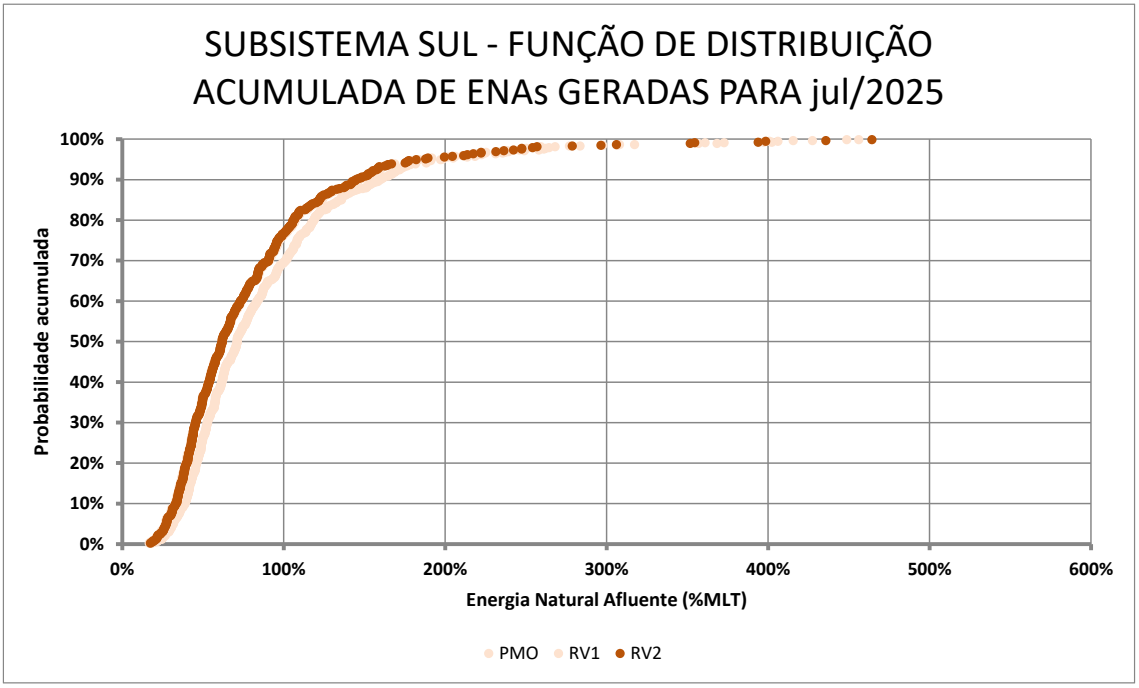

O conteúdo desta publicação foi produzido pelo ONS com base em dados e informações de conhecimento público. É de responsabilidade exclusiva dos agentes e demais interessados a obtenção de outros dados e informações, a realização de análises, estudos e avaliações para fins de tomada de decisões, definição de estratégias de atuação, assunção de compromissos e obrigações e quaisquer outras finalidades, em qualquer tempo e sob qualquer condição. É proibida a reprodução ou utilização total ou parcial do presente sem a identificação da fonte.

Figura 11 - Amplitude dos Cenários de ENA para o Subsistema Nordeste em %MLT, para a Revisão 2 de Junho/2025

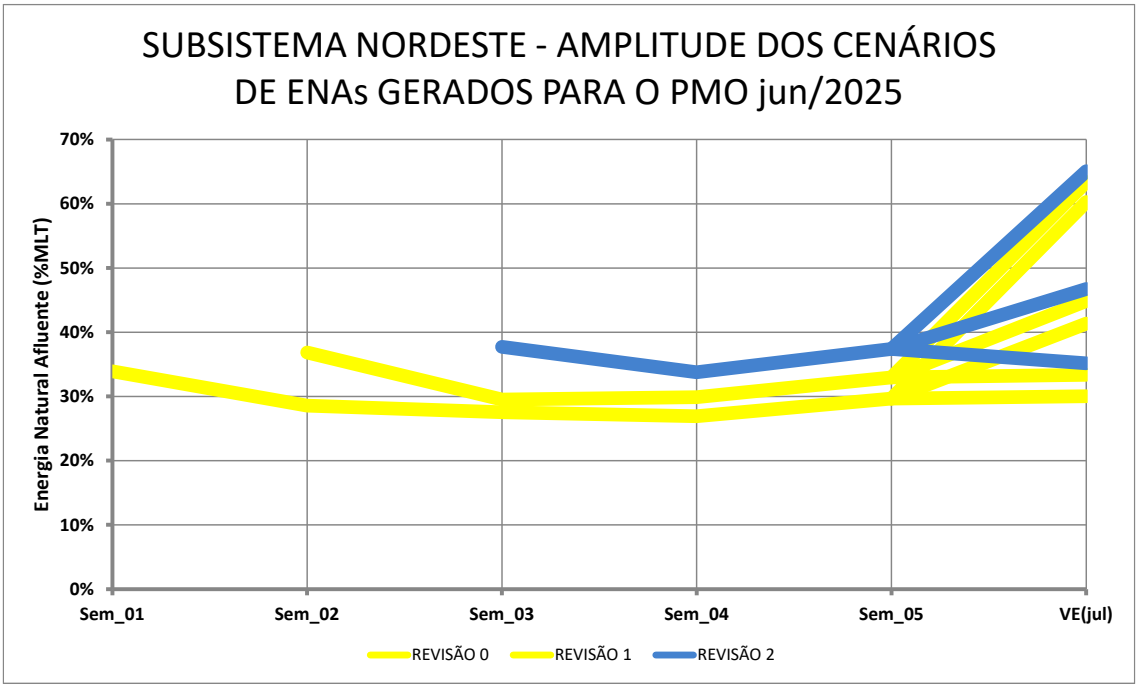

Figura 12 - Função de Distribuição Acumulada dos Cenários para o Subsistema Nordeste para a Revisão 2 de Junho/2025

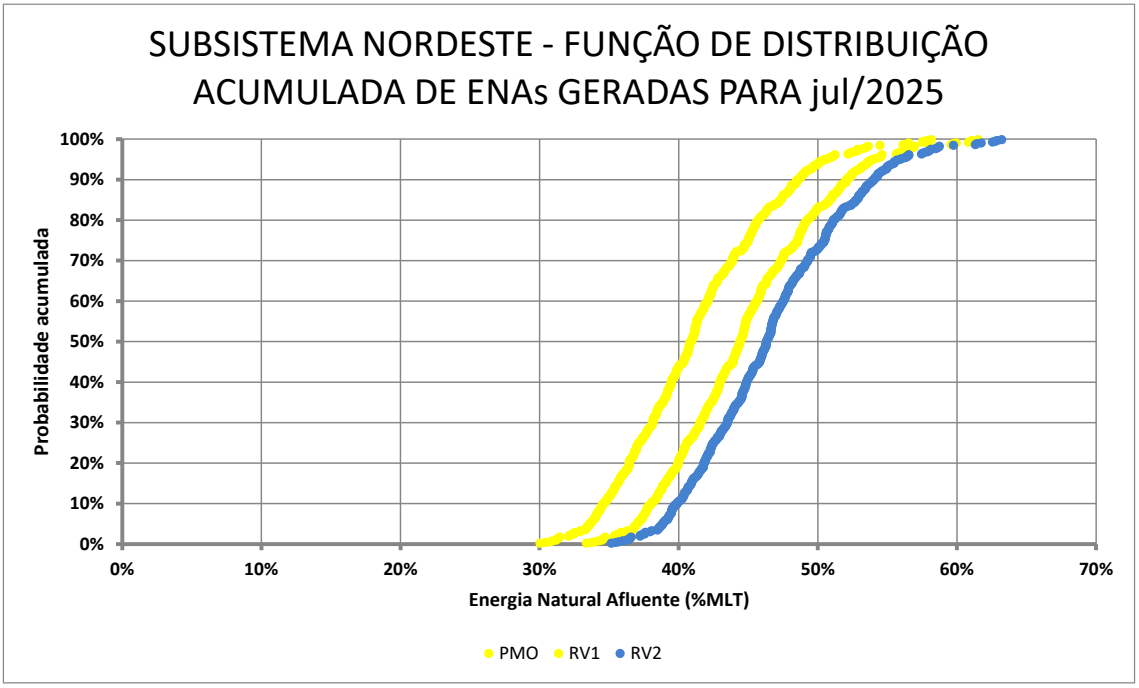

O conteúdo desta publicação foi produzido pelo ONS com base em dados e informações de conhecimento público. É de responsabilidade exclusiva dos agentes e demais interessados a obtenção de outros dados e informações, a realização de análises, estudos e avaliações para fins de tomada de decisões, definição de estratégias de atuação, assunção de compromissos e obrigações e quaisquer outras finalidades, em qualquer tempo e sob qualquer condição. É proibida a reprodução ou utilização total ou parcial do presente sem a identificação da fonte.

Figura 13 - Amplitude dos Cenários de ENA para o Subsistema Norte, em %MLT, para a Revisão 2 de Junho/2025

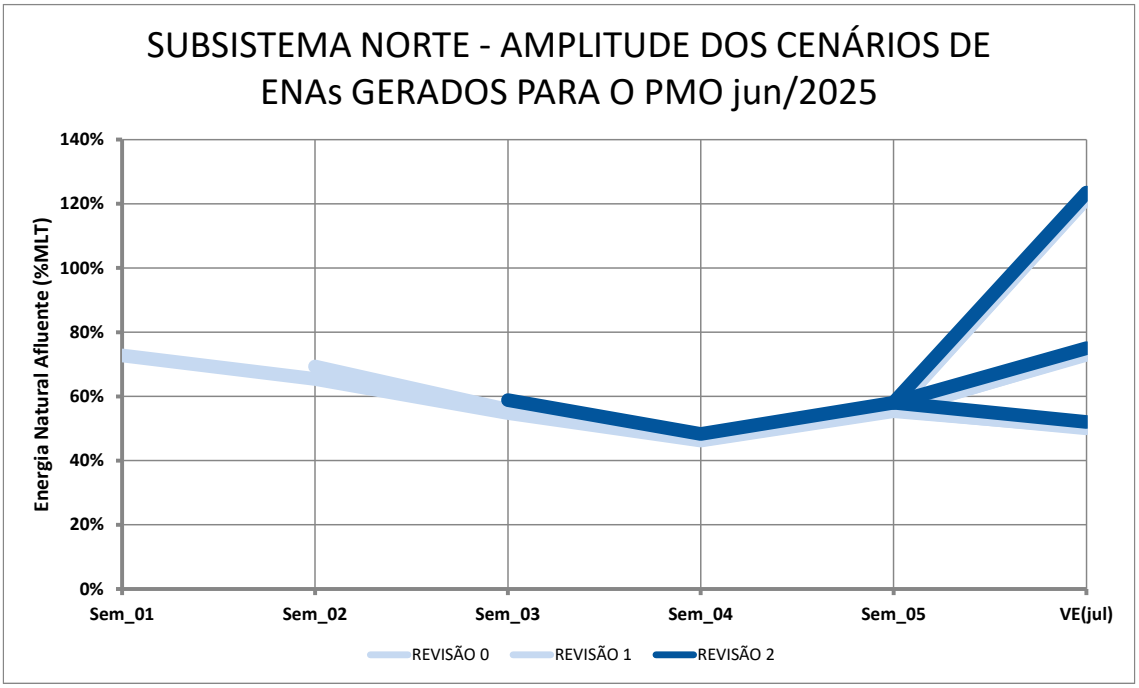

Figura 14 - Função de Distribuição Acumulada dos Cenários para o Subsistema Norte para a Revisão 2 de Junho/2025

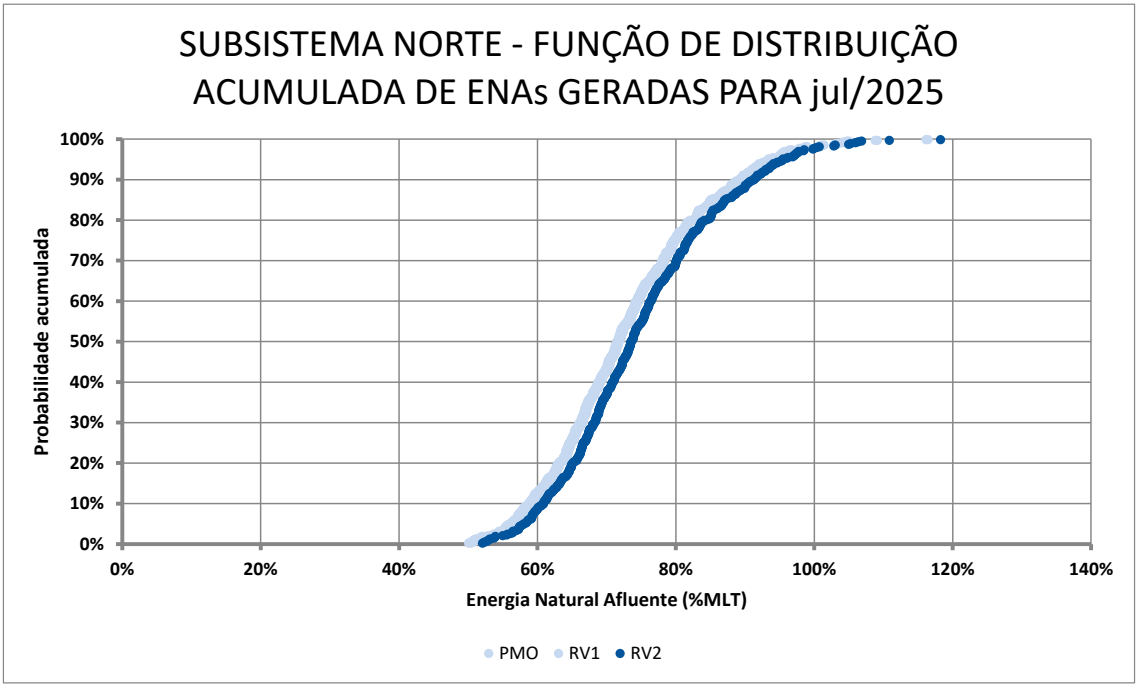

O conteúdo desta publicação foi produzido pelo ONS com base em dados e informações de conhecimento público. É de responsabilidade exclusiva dos agentes e demais interessados a obtenção de outros dados e informações, a realização de análises, estudos e avaliações para fins de tomada de decisões, definição de estratégias de atuação, assunção de compromissos e obrigações e quaisquer outras finalidades, em qualquer tempo e sob qualquer condição. É proibida a reprodução ou utilização total ou parcial do presente sem a identificação da fonte.

Os valores da MLT (Média de Longo Termo) das energias naturais afluentes para os meses de junho/2025 e julho/2025 são apresentados na tabela a seguir.

Tabela 3 – MLT da ENA nos meses de junho/2025 e julho/2025

MLT das ENAs (MWmed)		
Subsistema	junho	julho
SE/CO	32.541	25.581
S	10.573	10.957
NE	4.535	3.744
N	10.669	5.241

3.2. Limites de Intercâmbio entre Subsistemas

Os limites elétricos de intercâmbio de energia entre subsistemas são de fundamental importância para o processo de otimização energética, sendo determinantes para a definição das políticas de operação e do CMO para cada subsistema. Estes limites são influenciados por intervenções na malha de transmissão, notadamente na primeira semana operativa. O diagrama a seguir ilustra os fluxos notáveis do SIN e os limites aplicados neste PMO.

Figura 15 – Interligações entre regiões

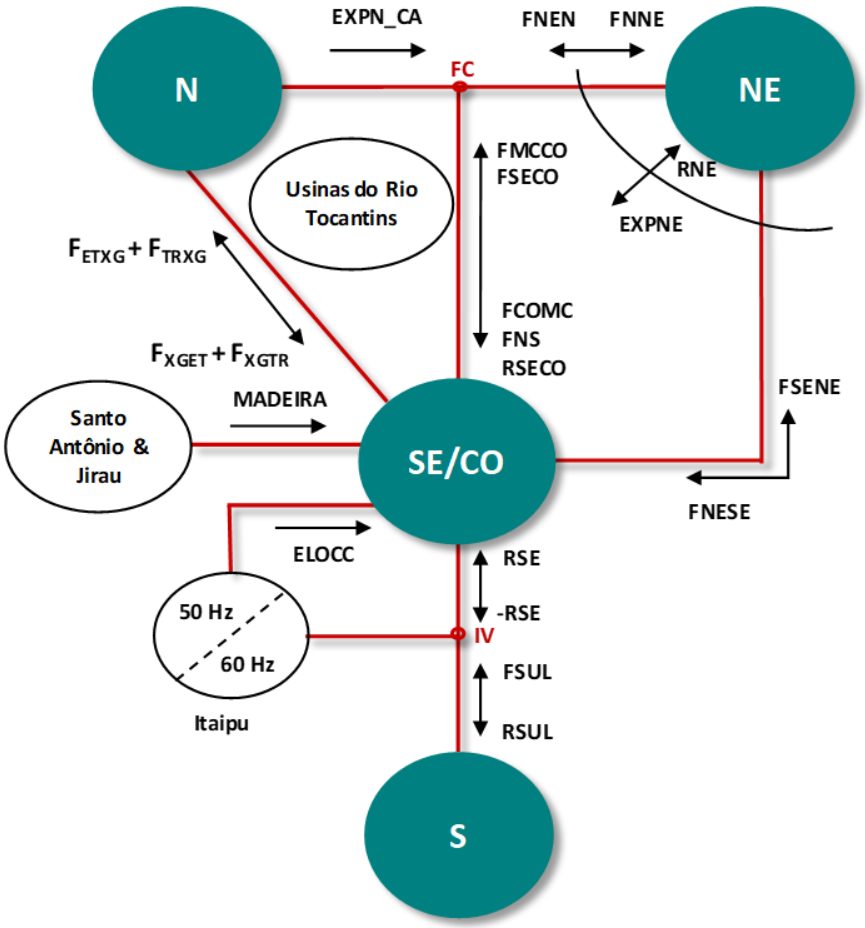

O conteúdo desta publicação foi produzido pelo ONS com base em dados e informações de conhecimento público. É de responsabilidade exclusiva dos agentes e demais interessados a obtenção de outros dados e informações, a realização de análises, estudos e avaliações para fins de tomada de decisões, definição de estratégias de atuação, assunção de compromissos e obrigações e quaisquer outras finalidades, em qualquer tempo e sob qualquer condição. É proibida a reprodução ou utilização total ou parcial do presente sem a identificação da fonte.

Tabela 4 – Limites considerados nesta semana operativa para intercâmbio de energia

Limites de Intercâmbio (MWmed)				
Fluxo	Patamar	14/06 a 20/06/2025		Demais Semanas
RNE	Pesada	11.000		11.000
	Média	11.000		11.000
	Leve	11.000		11.000
FNS	Pesada	**3.000**	(A) (B) (C) (D)	3.200
	Média	**3.000**		3.200
	Leve	**4.238**		5.000
FNNE	Pesada	7.800	(E) (F) (G)	7.800
	Média	**6.946**		7.800
	Leve	**6.984**		7.800
EXPORT. NE	Pesada	13.800		13.800
	Média	13.800		13.800
	Leve	13.800		13.800
FMCCO	Pesada	5.000		5.000
	Média	5.000		5.000
	Leve	5.000		5.000
FSENE	Pesada	6.000		6.000
	Média	6.000		6.000
	Leve	6.000		6.000
FNS + FNESE	Pesada	**7.500**	(A) (D) (H) (I) (J)	7.700
	Média	**5.902**		6.129
	Leve	**10.906**		11.200
RSE	Pesada	9.145		9.145
	Média	10.195		10.195
	Leve	10.355		10.355
FORNEC. SUL	Pesada	7.000		7.000
	Média	7.000		7.000
	Leve	8.600		8.600

Limites de Intercâmbio (MWmed)				
Fluxo	Patamar	14/06 a 20/06/2025		Demais Semanas
RECEB. SUL	Pesada	7.950		7.950
	Média	5.000		5.000
	Leve	8.650		8.650
ELO CC 50 Hz	Pesada	3.132	(K)	3.132
	Média	3.132		3.132
	Leve	**3.054**		3.132
ITAIPU 60 Hz	Pesada	**4.900**	(L)	7.500
	Média	**4.900**		7.500
	Leve	**4.900**		7.500
EXP. N CA	Pesada	8.000		8.000
	Média	8.000		8.000
	Leve	8.000		8.000
FETXG + FTRXG	Pesada	4.200		4.200
	Média	4.200		4.200
	Leve	4.200		4.200
FXGET + FXGTR	Pesada	8.000		8.000
	Média	8.000		8.000
	Leve	3.000		3.000
FNESE	Pesada	5.600	(B) (D) (H) (J) (M) (N)	5.600
	Média	**4.532**		4.559
	Leve	**7.651**		8.500
FNEN	Pesada	5.600	(E) (F) (G)	5.600
	Média	**5.417**		5.600
	Leve	**5.780**		6.200
Ger_MADEIRA	Pesada	7.278		7.278
	Média	7.278		7.278
	Leve	7.278		7.278

(A) SGI 32.691-25
(B) SGI 31.258-25
(C) SGI 33.943-25
(D) SGI 33.669-25
(E) SGI 33.512-25
(F) SGI 33.732-25
(G) SGI 33.741-25
(H) SGI 31.621-25
(I) SGI 31.345-25
(J) SGI 31.344-25
(K) SGI 34.004-25
(L) SGI 34.819-25
(M) SGI 32.037-25
(N) SGI 27.817-25

O conteúdo desta publicação foi produzido pelo ONS com base em dados e informações de conhecimento público. É de responsabilidade exclusiva dos agentes e demais interessados a obtenção de outros dados e informações, a realização de análises, estudos e avaliações para fins de tomada de decisões, definição de estratégias de atuação, assunção de compromissos e obrigações e quaisquer outras finalidades, em qualquer tempo e sob qualquer condição. É proibida a reprodução ou utilização total ou parcial do presente sem a identificação da fonte.

3.3. Previsão de carga

A partir do fechamento dos valores do PMO de Junho, as projeções de carga indicam variações de -2,1% no subsistema Sudeste/Centro-Oeste, 2,2% no subsistema Sul, 5,0% no subsistema Nordeste e 5,7% no subsistema Norte, em relação ao mesmo mês do ano anterior. Os principais fatores que explicam essas variações são descritos a seguir.

A estimativa de fechamento da carga global de energia na semana operativa atual (07/06 a 13/06) aponta, no Sistema Interligado Nacional (SIN), um resultado 0,8% inferior ao da semana anterior (31/05 a 06/06), consolidando uma expectativa de 76.383 MW médios.

Na análise por subsistemas, o Sudeste/Centro-Oeste apresentou decréscimo de 1,3% em relação à semana anterior, com desvio de 0,1%, evidenciando a boa assertividade da previsão para um subsistema com influência de fatores climáticos regionais. No Sul, a carga variou 0,9%, com desvio de -1,2%, também demonstrando bom desempenho preditivo em uma região de elevada complexidade.

Os Subsistemas Norte e Nordeste apresentaram desvios de -0,7% e 1,4%, respectivamente, com expectativas de fechamento de 8.139 e 13.319 MW médios. No Norte, o comportamento da carga é justificado pelo menor consumo energético por parte dos Consumidores Livres.

Para a próxima semana operativa (14/06 a 20/06), projeta-se redução de 1,7% na carga do SIN em relação à semana atual, influenciada pelo feriado de Corpus Christi, na quinta-feira. O efeito desse feriado tende a ser ampliado por anteceder a sexta-feira, favorecendo a formação de um fim de semana prolongado e deslocando a curva de carga para patamares mais baixos. Além disso, as premissas meteorológicas indicam temperaturas mais elevadas na próxima semana em boa parte do Sudeste e Sul, o que também pode impactar a carga, considerando que essas regiões registraram temperaturas mais baixas na semana vigente. Por fim, o Nordeste apresenta previsão de temperaturas semelhantes às atuais, porém com volumes maiores de precipitação em algumas capitais.

Tabela 5 – Evolução da carga do PMO de Junho de 2025

Subsistema	CARGA SEMANAL (MWmed)					CARGA MENSAL (MWmed)	
	1ª Sem	2ª Sem	3ª Sem	4ª Sem	5ª Sem	jun/25	Var. (%) jun/25 -> jun/24
SE/CO	42.286	41.723	41.045	42.413	41.718	41.838	-2,1%
Sul	13.087	13.202	12.984	13.253	13.154	13.135	2,2%
Nordeste	13.360	13.319	12.998	12.702	12.725	13.049	5,0%
Norte	8.256	8.139	8.051	8.173	8.104	8.146	5,7%
SIN	**76.990**	**76.383**	**75.078**	**76.541**	**75.701**	**76.169**	**0,6%**

O conteúdo desta publicação foi produzido pelo ONS com base em dados e informações de conhecimento público. É de responsabilidade exclusiva dos agentes e demais interessados a obtenção de outros dados e informações, a realização de análises, estudos e avaliações para fins de tomada de decisões, definição de estratégias de atuação, assunção de compromissos e obrigações e quaisquer outras finalidades, em qualquer tempo e sob qualquer condição. É proibida a reprodução ou utilização total ou parcial do presente sem a identificação da fonte.

3.4. Potência Hidráulica Total Disponível no SIN

O gráfico a seguir mostra a disponibilidade hidráulica total do SIN, para este mês, de acordo com o cronograma de manutenção informado pelos agentes para esta revisão.

Figura 16 – Potência hidráulica disponível no SIN

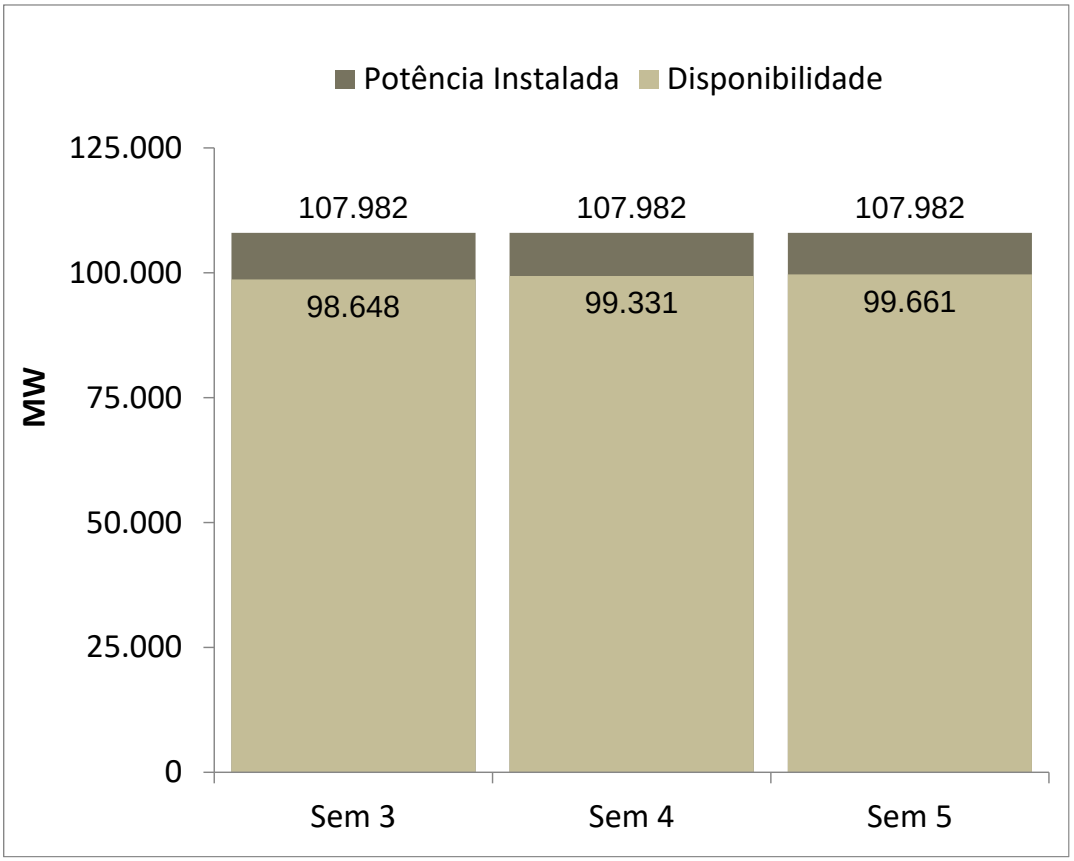

3.5. Armazenamentos Iniciais por Subsistema

Tabela 6 – Armazenamentos iniciais, por subsistema, considerados para esta semana operativa

Armazenamento (%EARmáx) - 0:00 h do dia 14/06/2025		
Subsistema	**Nível previsto na Revisão 1 do PMO Jun/2025**	**Partida informada pelos Agentes para a Revisão 2 do PMO Jun/2025**
SE/CO	67,6	67,7
S	43,2	43,1
NE	71,7	71,6
N	99,1	97,7

A primeira coluna da tabela acima corresponde ao armazenamento previsto na Revisão 1 do PMO de Junho de 2025, para a 0:00 h do dia 14/06/2025. A segunda coluna apresenta os armazenamentos obtidos a partir dos níveis de partida informados pelos Agentes de Geração para seus aproveitamentos com reservatórios.

O conteúdo desta publicação foi produzido pelo ONS com base em dados e informações de conhecimento público. É de responsabilidade exclusiva dos agentes e demais interessados a obtenção de outros dados e informações, a realização de análises, estudos e avaliações para fins de tomada de decisões, definição de estratégias de atuação, assunção de compromissos e obrigações e quaisquer outras finalidades, em qualquer tempo e sob qualquer condição. É proibida a reprodução ou utilização total ou parcial do presente sem a identificação da fonte.

4. PRINCIPAIS RESULTADOS

4.1. Política de Operação Energética

Para esta semana operativa, está prevista a seguinte política de intercâmbio de energia entre regiões:

Região SE/CO:

- Utilização dos recursos das bacias dos rios Grande e Paranaíba, conforme necessidade de alocação na carga para fechamento do balanço e controle de nível dos reservatórios;

- Expectativa de manutenção das defluências nas UHEs Jupiá e Porto Primavera.

Região Sul:

- Controle do nível dos reservatórios, visando recuperação de recursos;

- Controle de geração nas usinas de menor regularização, em função das previsões de vazão;

- Avaliação diária do despacho adicional GE (CMSE), com expectativa inicial de não haver despacho adicional.

Região NE:

- Subsistema exportador de energia;

- Operação minimizada na cascata do Rio São Francisco devido aos limites de interligação.

Região Norte:

- Subsistema exportador de energia em todos os patamares;

- Exploração das usinas das bacias do rio Tocantins e do rio Xingu, respeitando-se as restrições operativas e os limites elétricos vigentes. Geração na UHE Balbina para controle de nível, conforme simulação hidráulica.

O conteúdo desta publicação foi produzido pelo ONS com base em dados e informações de conhecimento público. É de responsabilidade exclusiva dos agentes e demais interessados a obtenção de outros dados e informações, a realização de análises, estudos e avaliações para fins de tomada de decisões, definição de estratégias de atuação, assunção de compromissos e obrigações e quaisquer outras finalidades, em qualquer tempo e sob qualquer condição. É proibida a reprodução ou utilização total ou parcial do presente sem a identificação da fonte.

4.2. Custo Marginal de Operação – CMO

A figura a seguir apresenta os Custos Marginais de Operação, em valores médios semanais, para as semanas operativas deste mês.

Figura 17 – CMO em valores médios

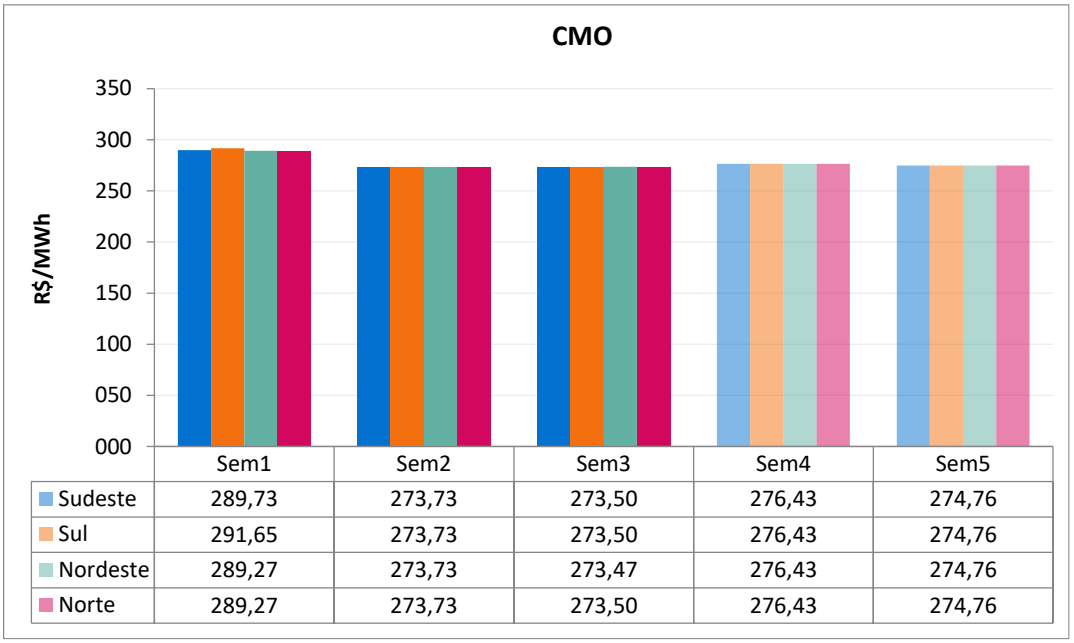

A tabela a seguir apresenta o custo marginal de operação, por subsistema e patamar de carga, para a próxima semana operativa.

Tabela 7 – CMO para esta semana operativa

Patamares de Carga	CMO (R$/MWh)			
	SE/CO	S	NE	N
Pesada	279,85	279,85	279,85	279,85
Média	274,02	274,02	273,92	274,02
Leve	271,73	271,73	271,73	271,73
Média Semanal	273,50	273,50	273,47	273,50

O conteúdo desta publicação foi produzido pelo ONS com base em dados e informações de conhecimento público. É de responsabilidade exclusiva dos agentes e demais interessados a obtenção de outros dados e informações, a realização de análises, estudos e avaliações para fins de tomada de decisões, definição de estratégias de atuação, assunção de compromissos e obrigações e quaisquer outras finalidades, em qualquer tempo e sob qualquer condição. É proibida a reprodução ou utilização total ou parcial do presente sem a identificação da fonte.

4.3. Energia Armazenada

O processo de otimização realizado pelo programa DECOMP indicou os armazenamentos mostrados na figura a seguir para as próximas semanas operativas do mês de junho/2025.

Figura 18 – Energias Armazenadas nas semanas operativas do mês de junho/2025

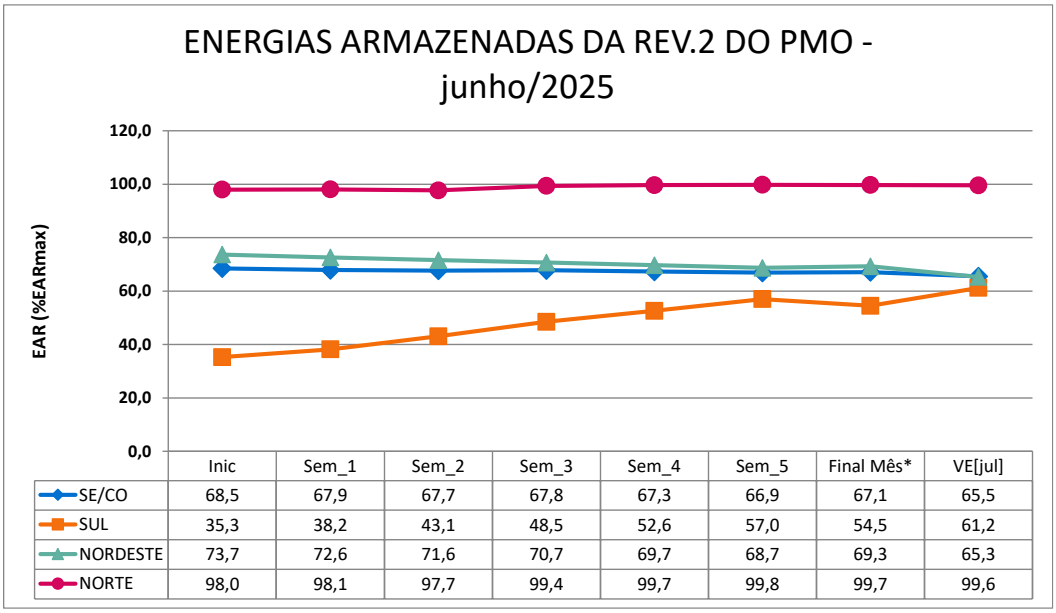

	Inic	Sem_1	Sem_2	Sem_3	Sem_4	Sem_5	Final Mês*	VE[jul]
SE/CO	68,5	67,9	67,7	67,8	67,3	66,9	67,1	65,5
SUL	35,3	38,2	43,1	48,5	52,6	57,0	54,5	61,2
NORDESTE	73,7	72,6	71,6	70,7	69,7	68,7	69,3	65,3
NORTE	98,0	98,1	97,7	99,4	99,7	99,8	99,7	99,6

Os armazenamentos da figura anterior estão expressos em percentual da Energia Armazenável Máxima de cada subsistema, que são mostradas na tabela a seguir.

Tabela 8 – Energia Armazenável Máxima por subsistema no PMO de Junho/2025

ENERGIA ARMAZENÁVEL MÁXIMA (MWmed)		
Subsistema	junho	julho
SE/CO	205.569	205.569
S	20.458	20.458
NE	51.718	51.718
N	14.795	15.297

O conteúdo desta publicação foi produzido pelo ONS com base em dados e informações de conhecimento público. É de responsabilidade exclusiva dos agentes e demais interessados a obtenção de outros dados e informações, a realização de análises, estudos e avaliações para fins de tomada de decisões, definição de estratégias de atuação, assunção de compromissos e obrigações e quaisquer outras finalidades, em qualquer tempo e sob qualquer condição. É proibida a reprodução ou utilização total ou parcial do presente sem a identificação da fonte.

5. GERAÇÃO TÉRMICA

A Figura 19 apresenta, para cada subsistema do SIN, o despacho térmico por modalidade indicado pelo Decomp para esta semana operativa.

Figura 19 – Geração térmica para a próxima semana operativa

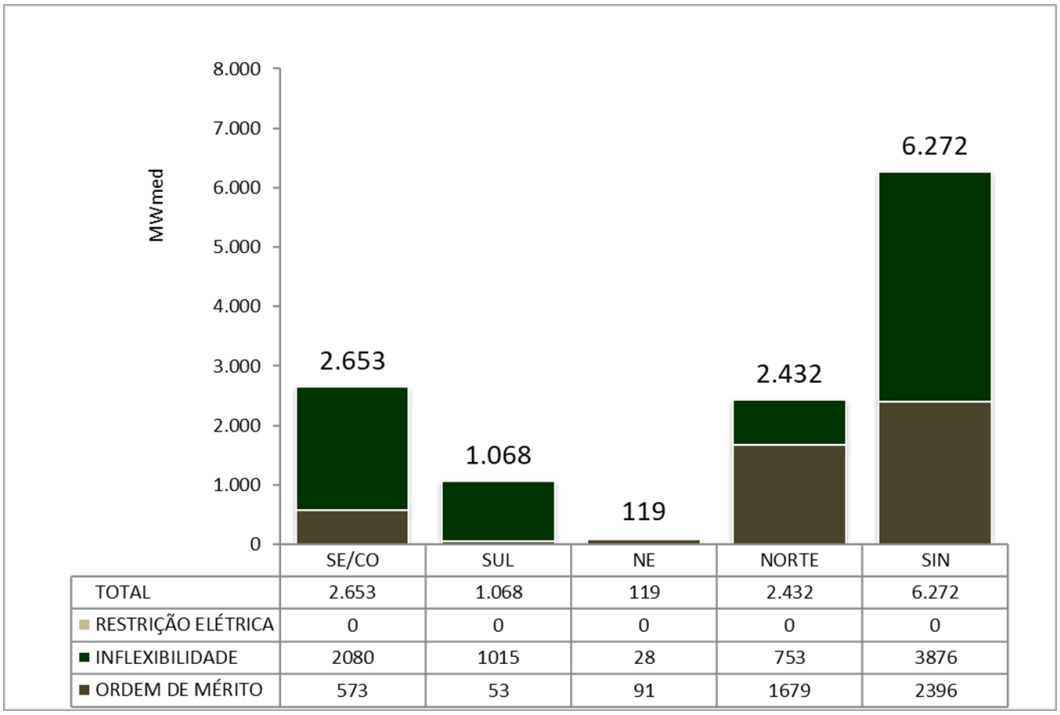

Na tabela abaixo segue a Indicação de despacho antecipado por ordem de mérito de custo para a semana de 16/08/2025 a 22/08/2025.

Tabela 9 – UTEs com contrato de combustível GNL

UTE			Benefício (R$/MWh)			Despacho antecipado por mérito		
Nome	Código	CVU (R$/MWh)	Carga Pesada	Carga Média	Carga Leve	Carga Pesada	Carga Média	Carga Leve
SANTA CRUZ	86	230,82	304,68	295,05	289,28	Sim	Sim	Sim
LUIZORMELO	15	349,22	304,68	295,05	289,28	Não	Não	Não
PSERGIPE I	224	314,65	297,33	292,42	289,26	Não	Não	Não

Assim sendo, há indicação de despacho antecipado por ordem de mérito de custo para a UTE Santa Cruz para a semana de 16/08/2025 a 22/08/2025 nos três patamares de carga.

Para as UTEs Luiz O. R. Melo e Porto Sergipe I, não há indicação de despacho antecipado.

O conteúdo desta publicação foi produzido pelo ONS com base em dados e informações de conhecimento público. É de responsabilidade exclusiva dos agentes e demais interessados a obtenção de outros dados e informações, a realização de análises, estudos e avaliações para fins de tomada de decisões, definição de estratégias de atuação, assunção de compromissos e obrigações e quaisquer outras finalidades, em qualquer tempo e sob qualquer condição. É proibida a reprodução ou utilização total ou parcial do presente sem a identificação da fonte.

6. RESUMO DOS RESULTADOS DO PMO

As figuras a seguir apresentam um resumo dos resultados da Revisão 2 de junho/2025, com informações da Energia Natural Afluente (ENA), da Energia Armazenada (EAR) e do Custo Marginal de Operação (CMO) nos subsistemas do Sistema Interligado Nacional (SIN). São apresentados os valores semanais observados e previstos e o valor esperado dos cenários gerados para o mês de julho/2025.

Figura 20 – Resumo de junho/2025 para o Subsistema Sudeste/Centro-Oeste

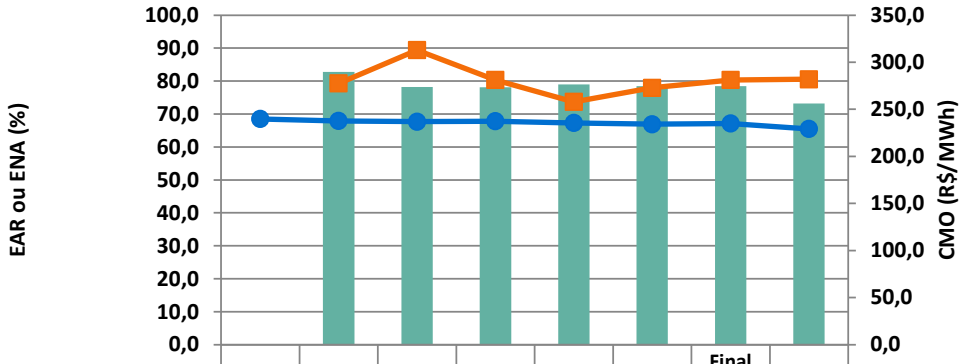

	Inic	Sem_1	Sem_2	Sem_3	Sem_4	Sem_5	Final Mês*	VE[jul]
CMO (R$/MWh)		289,73	273,73	273,50	276,43	274,76	274,76	256,13
EAR(%EARmax)	68,5	67,9	67,7	67,8	67,3	66,9	67,1	65,5
ENA(%mlt)		79,3	89,4	80,3	73,7	78,0	80,3	80,6

Figura 21– Resumo de junho/2025 para o Subsistema Sul

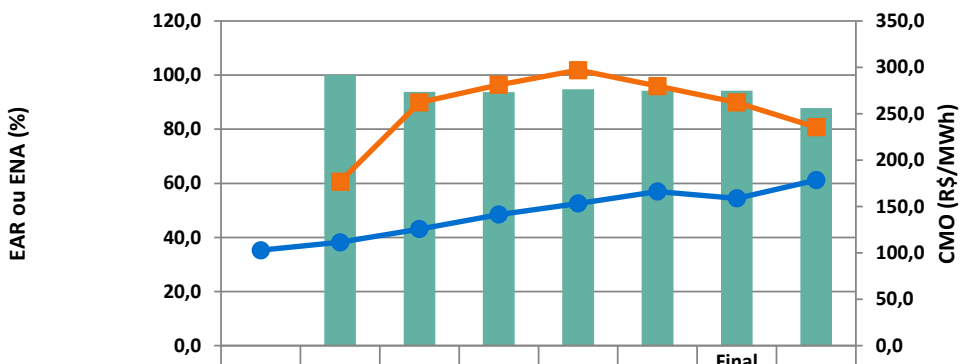

	Inic	Sem_1	Sem_2	Sem_3	Sem_4	Sem_5	Final Mês*	VE[jul]
CMO (R$/MWh)		291,65	273,73	273,50	276,43	274,76	274,76	256,13
EAR(%EARmax)	35,3	38,2	43,1	48,5	52,6	57,0	54,5	61,2
ENA(%mlt)		60,6	89,9	96,4	101,9	96,0	89,9	80,8

O conteúdo desta publicação foi produzido pelo ONS com base em dados e informações de conhecimento público. É de responsabilidade exclusiva dos agentes e demais interessados a obtenção de outros dados e informações, a realização de análises, estudos e avaliações para fins de tomada de decisões, definição de estratégias de atuação, assunção de compromissos e obrigações e quaisquer outras finalidades, em qualquer tempo e sob qualquer condição. É proibida a reprodução ou utilização total ou parcial do presente sem a identificação da fonte.

Figura 22– Resumo de junho/2025 para o Subsistema Nordeste

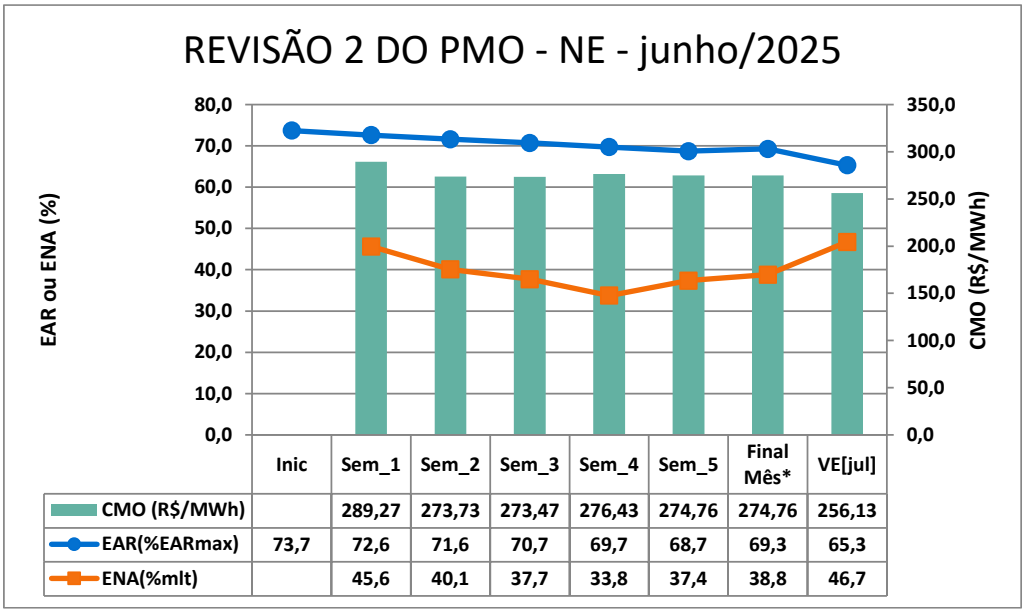

	Inic	Sem_1	Sem_2	Sem_3	Sem_4	Sem_5	Final Mês*	VE[jul]
CMO (R$/MWh)		289,27	273,73	273,47	276,43	274,76	274,76	256,13
EAR(%EARmax)	73,7	72,6	71,6	70,7	69,7	68,7	69,3	65,3
ENA(%mlt)		45,6	40,1	37,7	33,8	37,4	38,8	46,7

Figura 23 – Resumo de junho/2025 para o Subsistema Norte

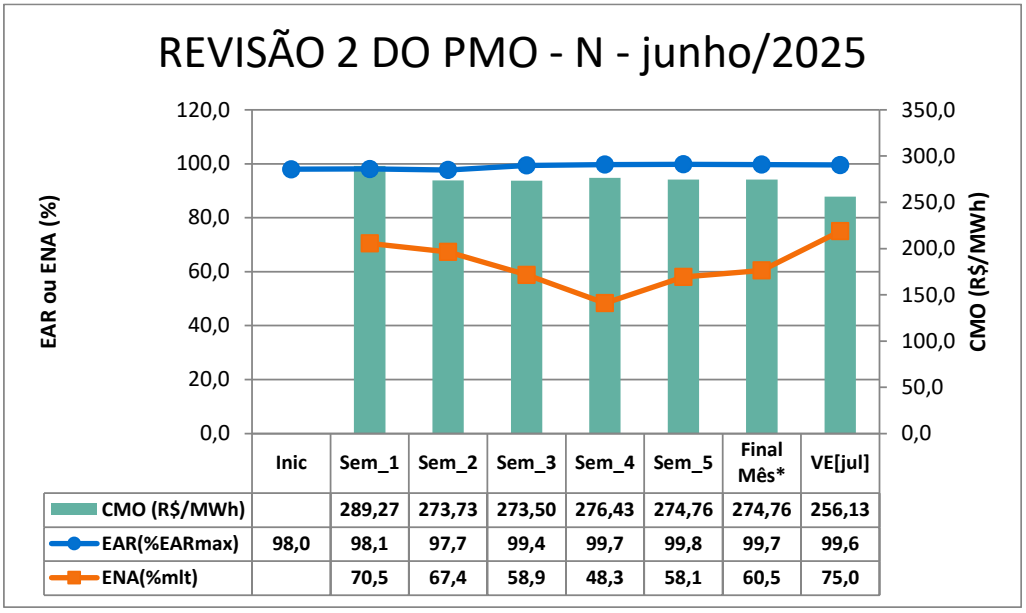

	Inic	Sem_1	Sem_2	Sem_3	Sem_4	Sem_5	Final Mês*	VE[jul]
CMO (R$/MWh)		289,27	273,73	273,50	276,43	274,76	274,76	256,13
EAR(%EARmax)	98,0	98,1	97,7	99,4	99,7	99,8	99,7	99,6
ENA(%mlt)		70,5	67,4	58,9	48,3	58,1	60,5	75,0

O conteúdo desta publicação foi produzido pelo ONS com base em dados e informações de conhecimento público. É de responsabilidade exclusiva dos agentes e demais interessados a obtenção de outros dados e informações, a realização de análises, estudos e avaliações para fins de tomada de decisões, definição de estratégias de atuação, assunção de compromissos e obrigações e quaisquer outras finalidades, em qualquer tempo e sob qualquer condição. É proibida a reprodução ou utilização total ou parcial do presente sem a identificação da fonte.

7. ARMAZENAMENTOS OPERATIVOS

Para uma melhor avaliação de diversos cenários hidrometeorológicos, notadamente, aqueles de curto prazo e suas influências nas previsões de vazões nos subsistemas, os resultados desta revisão do PMO contemplam cenários de afluências visando melhor representar a ocorrência de precipitação e, consequentemente, seus efeitos sobre as afluências e armazenamentos.

Apresentamos a seguir as correspondentes energias naturais afluentes e os resultados obtidos com a aplicação do cenário de afluência utilizado no estudo.

Tabela 9 – Previsão de ENA do caso de valor esperado das previsões de afluência

Subsistema	ENERGIAS NATURAIS AFLUENTES			
	Previsão Semanal		Previsão Mensal	
	(MWmed)	%MLT	(MWmed)	%MLT
SE/CO	26.147	80	26.148	80
Sul	10.193	96	9.506	90
Nordeste	1.711	38	1.760	39
Norte	6.166	58	6.452	60

Tabela 10 – Previsão de %EARmáx para o final do mês

Subsistema	% EARmáx 13/06	% EARmáx - 30/06
	NÍVEL INICIAL	NÍVEL PMO
SE/CO	67,7	67,1
Sul	43,1	54,5
Nordeste	71,6	69,3
Norte	97,7	99,7

O conteúdo desta publicação foi produzido pelo ONS com base em dados e informações de conhecimento público. É de responsabilidade exclusiva dos agentes e demais interessados a obtenção de outros dados e informações, a realização de análises, estudos e avaliações para fins de tomada de decisões, definição de estratégias de atuação, assunção de compromissos e obrigações e quaisquer outras finalidades, em qualquer tempo e sob qualquer condição. É proibida a reprodução ou utilização total ou parcial do presente sem a identificação da fonte.

8. RESERVATÓRIOS EQUIVALENTES DE ENERGIA

A seguir são apresentadas as previsões de Energia Natural Afluente para a próxima semana operativa e para o mês de junho, bem como as previsões de Energia Armazenada nos Reservatórios Equivalentes de Energia – REE, desta revisão do PMO de Junho de 2025.

Tabela 11 – Previsão de ENA por REE

Valor Esperado das Energias Naturais Afluentes				
REE	Previsão Semanal		Previsão Mensal	
	14/06/2025 a 20/06/2025		jun-25	
	(MWmed)	%MLT	(MWmed)	%MLT
Sudeste	2.422	68	2.533	71
Madeira	7.169	118	7.257	119
Teles Pires	1.185	85	1.228	88
Itaipu	3.306	92	2.913	81
Paraná	10.220	67	10.357	68
Paranapanema	1.842	71	1.845	71
Sul	5.458	101	4.981	92
Iguaçu	4.734	92	4.525	88
Nordeste	1.711	38	1.760	39
Norte	2.431	56	2.556	58
Belo Monte	2.551	53	2.844	59
Manaus	1.298	89	1.255	86

Tabela 12 – Previsão de %EARmáx por REE

% Energia Armazenável Máxima		
REE	Previsão Semanal	Previsão Mensal
	20-jun	30-jun
	(%EARmáx)	(%EARmáx)
Sudeste	71,7	70,3
Madeira	88,6	87,8
Teles Pires	76,7	75,9
Itaipu	100,0	100,0
Paraná	66,3	65,8
Paranapanema	65,6	66,9
Sul	41,7	50,5
Iguaçu	55,1	58,3
Nordeste	70,7	69,3
Norte	99,7	99,9
Belo Monte	100,0	100,0
Manaus	93,9	96,8

O conteúdo desta publicação foi produzido pelo ONS com base em dados e informações de conhecimento público. É de responsabilidade exclusiva dos agentes e demais interessados a obtenção de outros dados e informações, a realização de análises, estudos e avaliações para fins de tomada de decisões, definição de estratégias de atuação, assunção de compromissos e obrigações e quaisquer outras finalidades, em qualquer tempo e sob qualquer condição. É proibida a reprodução ou utilização total ou parcial do presente sem a identificação da fonte.

9. DESPACHO TÉRMICO POR MODALIDADE, PATAMAR DE CARGA E USINA

Nas tabelas abaixo, a diferenciação entre geração por inflexibilidade e por ordem de mérito tem caráter informativo, com o objetivo de detalhar a informação de inflexibilidade enviada pelos respectivos agentes para esta revisão do PMO. Ressalta-se que nas etapas de Programação Diária e Tempo Real, o montante despachado nas usinas termelétricas indicadas por ordem de mérito é plenamente intitulado como ordem de mérito.

REGIÃO SUDESTE/CENTRO-OESTE

Térmicas Potência (MW)	Combustível		Inflexibilidade			Ordem de Mérito			Total Mérito e INFL.			Razão Elétrica			Total UTE		
			P	M	L	P	M	L	P	M	L	P	M	L	P	M	L
ATLAN_CSA (255)	Resíduos	0,00	82,5	82,5	82,5				82,5	82,5	82,5				82,5	82,5	82,5
DAIA (44)	Diesel	---															
TNORTE 2 (349)	Óleo	---															
W.ARJONA O (177)	Diesel	---															
XAVANTES (54)	Diesel	---															
ANGRA 2 (1350)	Nuclear	20,12	1350,0	1350,0	1350,0	0,0	0,0	0,0	1350,0	1350,0	1350,0				1350,0	1350,0	1350,0
ANGRA 1 (640)	Nuclear	31,17				0,0	0,0	0,0									
M.AZUL (566)	Gás	136,49				0,0	0,0	0,0									
O.PINTADA (50)	Biomassa	145,52	30,0	30,0	30,0	20,0	20,0	20,0	50,0	50,0	50,0				50,0	50,0	50,0
UTE STA VI (41)	Biomassa	157,20	18,0	18,0	18,0	23,0	23,0	23,0	41,0	41,0	41,0				41,0	41,0	41,0
BAIXADA FL (530)	Gás	227,09				530,0	530,0	530,0	530,0	530,0	530,0				530,0	530,0	530,0
SANTA CRUZ (500)	GNL	230,82															
ATLANTICO (235)	Resíduos	256,90	218,7	218,7	218,7				218,7	218,7	218,7				218,7	218,7	218,7
ST.CRUZ 34 (436)	Óleo	310,41															
LUIZORMELO (204)	GNL	349,22															
CUBATAO (216)	Gás	430,27	105,0	96,0	82,0				105,0	96,0	82,0				105,0	96,0	82,0
UTE GNA I (1338)	Gás	440,62															
PIRAT.12 O (200)	Gás	470,34															
UTE GNA II (1673)	Gás	560,12															
IBIRITE (235)	Gás	767,28	57,0	62,0	69,0				57,0	62,0	69,0				57,0	62,0	69,0
TERMORIO (989)	Gás	866,87	148,0	135,0	116,0				148,0	135,0	116,0				148,0	135,0	116,0
KARKEY 013 (259)	Gás	876,64	31,0	31,0	31,0				31,0	31,0	31,0				31,0	31,0	31,0
KARKEY 019 (116)	Gás	876,64															
NORTEFLU (826)	Gás	884,63															
T.LAGOAS (350)	Gás	909,79															
T.MACAE (922)	Gás	956,68	200,0	82,0					200,0	82,0					200,0	82,0	0,0
PORSUD II (78)	Gás	1029,18															
PORSUD I (116)	Gás	1029,46															
CUIABA CC (529)	Gás	1046,82															
J.FORA (87)	Gás	1105,44															
SEROPEDICA (360)	Gás	1155,42															
VIANA (175)	Óleo	1161,62															
PAULINIA (16)	Gás	1252,64	15,7	15,7	15,7				15,7	15,7	15,7				15,7	15,7	15,7
LORM_PCS (36)	Gás	1274,48															
POVOACAO I (75)	Gás	1274,48															
VIANA I (37)	Gás	1274,48															
NPIRATINGA (572)	Gás	1318,22															
PALMEIR_GO (176)	Diesel	1438,16															
W.ARJONA (177)	Gás	1461,52															
TOTAL SE/CO (14989)			2255,9	2120,9	2012,9	573,0	573,0	573,0	2828,9	2693,9	2585,9	0,0	0,0	0,0	2828,9	2693,9	2585,9

REGIÃO SUL

Térmicas Potência (MW)	Combustível		Inflexibilidade			Ordem de Mérito			Total Mérito e INFL.			Razão Elétrica			Total UTE		
			P	M	L	P	M	L	P	M	L	P	M	L	P	M	L
PAMPA SUL (345)	Carvão	101,20	300,0	300,0	300,0	45,0	45,0	45,0	345,0	345,0	345,0				345,0	345,0	345,0
SAO SEPE (8)	Biomassa	113,53				8,0	8,0	8,0	8,0	8,0	8,0				8,0	8,0	8,0
FIGUEIRA (20)	Carvão	330,64															
J.LACER. C (330)	Carvão	341,04	300,0	300,0	300,0				300,0	300,0	300,0				300,0	300,0	300,0
J.LACER. B (220)	Carvão	397,24	110,0	110,0	110,0				110,0	110,0	110,0				110,0	110,0	110,0
J.LAC. A2 (110)	Carvão	406,63	55,0	55,0	55,0				55,0	55,0	55,0				55,0	55,0	55,0
J.LAC. A1 (80)	Carvão	475,13	40,0	40,0	40,0				40,0	40,0	40,0				40,0	40,0	40,0
CANDIOTA_3 (350)	Carvão	524,78	210,0	210,0	210,0				210,0	210,0	210,0				210,0	210,0	210,0
ARAUCARIA (484)	Gás	707,74															
URUGUAIANA (640)	Gás	774,41															
B.BONITA I (10)	Gás	778,35															
CANOAS (249)	Gás	1277,30															
TOTAL SUL (2846)			1015,0	1015,0	1015,0	53,0	53,0	53,0	1068,0	1068,0	1068,0	0,0	0,0	0,0	1068,0	1068,0	1068,0

O conteúdo desta publicação foi produzido pelo ONS com base em dados e informações de conhecimento público. É de responsabilidade exclusiva dos agentes e demais interessados a obtenção de outros dados e informações, a realização de análises, estudos e avaliações para fins de tomada de decisões, definição de estratégias de atuação, assunção de compromissos e obrigações e quaisquer outras finalidades, em qualquer tempo e sob qualquer condição. É proibida a reprodução ou utilização total ou parcial do presente sem a identificação da fonte.

REGIÃO NORDESTE

Térmicas Potência (MW)	Combustível		Inflexibilidade			Ordem de Mérito			Total Mérito e INFL.			Razão Elétrica			Total UTE		
			P	M	L	P	M	L	P	M	L	P	M	L	P	M	L
CAMPINA_GR (169)	Óleo	---															
GLOBAL I (149)	Óleo	---															
GLOBAL II (149)	Óleo	---															
MARACANAU (168)	Óleo	---															
PETROLINA (136)	Óleo	---															
POTIGUAR (53)	Diesel	---															
POTIGUAR_3 (66)	Diesel	---															
TERMOCABO (50)	Óleo	---															
TERMONE (171)	Óleo	---															
TERMOPB (171)	Óleo	---															
ERB CANDEI (17)	Biomassa	113,61	3,5	3,5	3,5	8,5	8,5	8,5	12,0	12,0	12,0				12,0	12,0	12,0
PROSP_I (28)	Gás	214,28				28,0	27,2	26,0	28,0	27,2	26,0				28,0	27,2	26,0
PROSP_III (56)	Gás	218,33				56,0	56,0	56,0	56,0	56,0	56,0				56,0	56,0	56,0
P.PECEM1 (720)	Carvão	311,05															
PSERGIPE I (1593)	GNL	314,65	57,0	50,0					57,0	50,0					57,0	50,0	
P.PECEM2 (365)	Carvão	320,42															
PROSP_II (37)	Gás	328,17															
VALE ACU (110)	Gás	450,86															
T.BAHIA (186)	Gás	663,53															
PERNAMBU_3 (201)	Óleo	819,54															
TERMOPE (550)	Gás	930,84															
SUAPE II (381)	Óleo	969,93															
TERMOCEARA (223)	Gás	1938,83															
C.MURICY 2 (144)	Óleo	2319,04															
PECEM 2 (144)	Óleo	2343,17															
TOTAL NE (5749)			60,5	53,5	3,5	149,5	141,7	90,5	210,0	195,2	94,0	0,0	0,0	0,0	210,0	195,2	94,0

REGIÃO NORTE

Térmicas Potência (MW)	Combustível		Inflexibilidade			Ordem de Mérito			Total Mérito e INFL.			Razão Elétrica			Total UTE		
			P	M	L	P	M	L	P	M	L	P	M	L	P	M	L
MARANHAO3 (519)	Gás	110,91				501,5	500,7	512,0	501,5	500,7	512,0				501,5	500,7	512,0
APARECIDA (166)	Gás	114,11	75,0	75,0	75,0	39,0	39,0	39,0	114,0	114,0	114,0				114,0	114,0	114,0
C. ROCHA (85)	Gás	114,11	28,0	28,0	28,0	39,0	39,0	39,0	67,0	67,0	67,0				67,0	67,0	67,0
JARAQUI (75)	Gás	114,11	29,0	29,0	29,0	34,0	34,0	34,0	63,0	63,0	63,0				63,0	63,0	63,0
MANAUARA (73)	Gás	114,11	35,0	35,0	35,0	32,0	32,0	32,0	67,0	67,0	67,0				67,0	67,0	67,0
PONTA NEGR (73)	Gás	114,11	35,0	35,0	35,0	29,0	29,0	29,0	64,0	64,0	64,0				64,0	64,0	64,0
TAMBAQUI (93)	Gás	114,11	33,0	33,0	33,0	30,0	30,0	30,0	63,0	63,0	63,0				63,0	63,0	63,0
UTE MAUA 3 (591)	Gás	114,11	264,0	264,0	264,0	326,8	326,8	326,8	590,8	590,8	590,8				590,8	590,8	590,8
MARANHAO V (338)	Gás	213,68	57,0	42,0	21,0	273,0	287,7	313,6	330,0	329,7	334,6				330,0	329,7	334,6
MARANHAOIV (338)	Gás	213,68	57,0	42,0	21,0	273,0	287,7	270,0	330,0	329,7	291,0				330,0	329,7	291,0
PARNAIBA_V (386)	Vapor	233,55				89,0	97,2	41,0	89,0	97,2	41,0				89,0	97,2	41,0
N.VENECIA2 (270)	Gás	294,56	180,0	180,0	180,0				180,0	180,0	180,0				180,0	180,0	180,0
P. ITAQUI (360)	Carvão	312,59															
PARNAIB_IV (56)	Gás	405,04	15,0	11,0	6,0				15,0	11,0	6,0				15,0	11,0	6,0
GERAMAR1 (166)	Óleo	1216,90															
GERAMAR2 (166)	Óleo	1216,90															
TOTAL NORTE (4045)			808,0	774,0	727,0	1666,3	1703,1	1666,4	2474,3	2477,1	2393,4	0,0	0,0	0,0	2474,3	2477,1	2393,4

O conteúdo desta publicação foi produzido pelo ONS com base em dados e informações de conhecimento público. É de responsabilidade exclusiva dos agentes e demais interessados a obtenção de outros dados e informações, a realização de análises, estudos e avaliações para fins de tomada de decisões, definição de estratégias de atuação, assunção de compromissos e obrigações e quaisquer outras finalidades, em qualquer tempo e sob qualquer condição. É proibida a reprodução ou utilização total ou parcial do presente sem a identificação da fonte.