1. APRESENTAÇÃO

Na semana de 12/10/2024 a 18/10/2024, foi observada precipitação nas bacias das regiões Sul, Sudeste e no litoral do Nordeste, e o favorecimento da organização de precipitação em pontos isolados das bacias dos rios Tocantins e Tapajós.

Para a semana de 19/10/2024 a 25/10/2024, está prevista chuva nas principais bacias do SIN. Os maiores acumulados são para a bacia do rio Paranaíba e para os trechos médio e alto das bacias dos rios Tocantins e São Francisco.

Os valores médios semanais do Custo Marginal de Operação – CMO dos subsistemas do SIN sofreram as seguintes alterações em relação à semana anterior:

- SE/CO: de R$ 571,67/MWh para R$ 460,62/MWh
- Sul: de R$ 571,67/MWh para R$ 460,62/MWh
- Nordeste: de R$ 571,67/MWh para R$ 460,62/MWh
- Norte: de R$ 571,67/MWh para R$ 460,62/MWh

Desde o dia 01/01/2020, o despacho por ordem de mérito é indicado diariamente pelos resultados do modelo DESSEM. Assim, o despacho por ordem de mérito semanal, conforme publicado nesse documento, tem caráter apenas informativo. Da mesma forma, desde o dia 01/01/2021, a formação de preço deixou o formato semanal/patamar de carga e passou a ser horário, de acordo também com os resultados do modelo DESSEM.

2. NOTÍCIAS

Nos dias 24 e 25 de outubro será realizada a reunião de elaboração do PMO de Novembro de 2024, com transmissão ao vivo através do site do ONS.

3. INFORMAÇÕES CONJUNTURAIS PARA ELABORAÇÃO DO PMO

3.1. Informações Hidrometeorológicas

3.1.1. Condições antecedentes

O avanço de uma frente fria pelas regiões Sul, Sudeste e litoral do Nordeste e a atuação de áreas de instabilidade provocaram precipitação nas bacias destas regiões e favoreceram a organização da precipitação em pontos isolados das bacias dos rios Tocantins e Tapajós (Figura 1).

O conteúdo desta publicação foi produzido pelo ONS com base em dados e informações de conhecimento público. É de responsabilidade exclusiva dos agentes e demais interessados a obtenção de outros dados e informações, a realização de análises, estudos e avaliações para fins de tomada de decisões, definição de estratégias de atuação, assunção de compromissos e obrigações e quaisquer outras finalidades, em qualquer tempo e sob qualquer condição. É proibida a reprodução ou utilização total ou parcial do presente sem a identificação da fonte.

Figura 1 - Precipitação observada por satélite (mm) no período de 12 a 17/10/2024

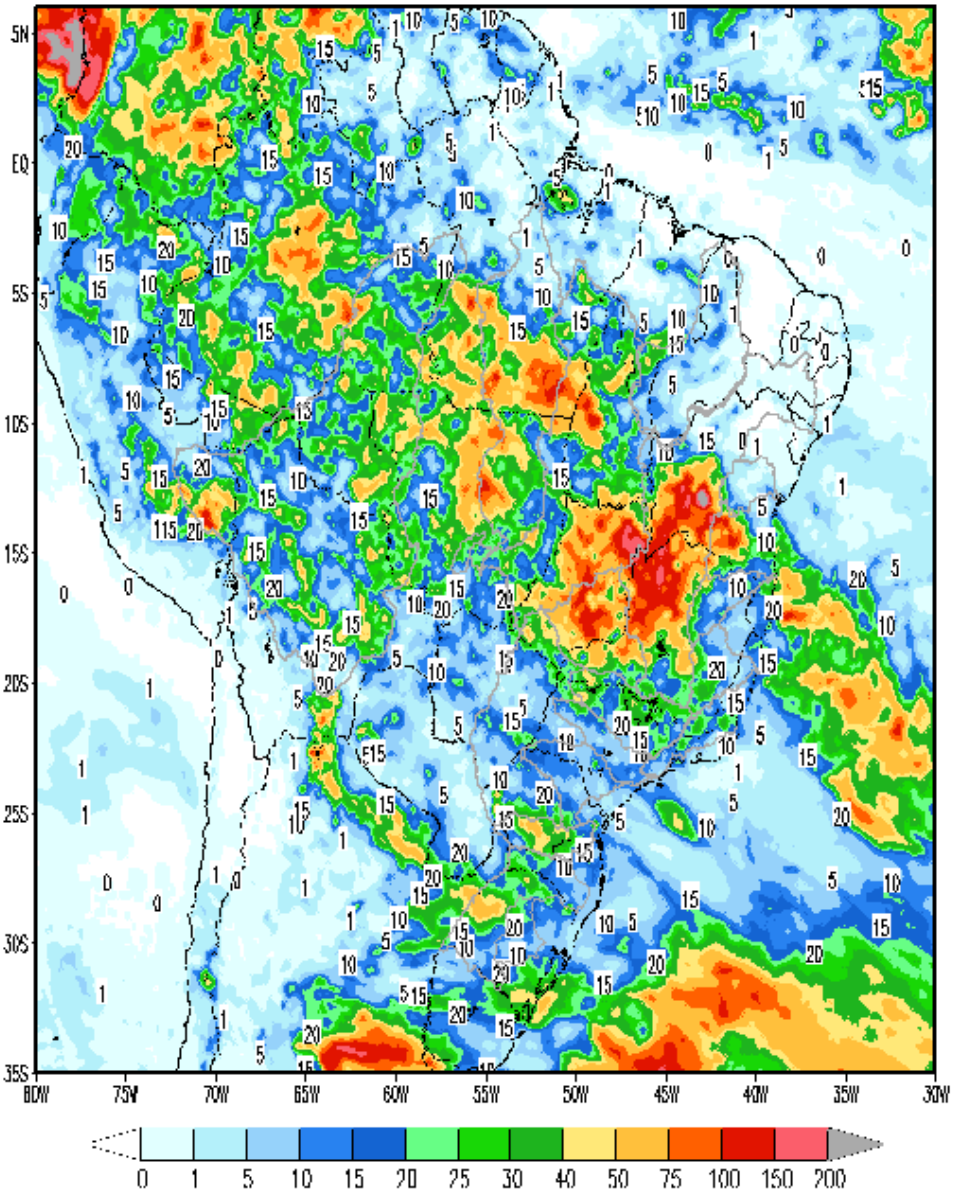

A Tabela 1 apresenta as energias naturais afluentes das semanas recentes. São apresentados os valores verificados na semana 05/10/2024 a 11/10/2024 e os estimados para fechamento da semana de 12/10/2024 a 18/10/2024.

Tabela 1 – Tendência hidrológica da ENA da Revisão 3 de Outubro/2024

Revisão 3 do PMO de Outubro/2024 - ENAs				
Subsistema	05/10 a 11/10/2024		12/10 a 18/10/2024	
	MWmed	%MLT	MWmed	%MLT
SE/CO	8.509	36	10.978	46
S	11.023	83	16.606	124
NE	989	31	849	27
N	959	40	1.039	44

O conteúdo desta publicação foi produzido pelo ONS com base em dados e informações de conhecimento público. É de responsabilidade exclusiva dos agentes e demais interessados a obtenção de outros dados e informações, a realização de análises, estudos e avaliações para fins de tomada de decisões, definição de estratégias de atuação, assunção de compromissos e obrigações e quaisquer outras finalidades, em qualquer tempo e sob qualquer condição. É proibida a reprodução ou utilização total ou parcial do presente sem a identificação da fonte.

3.1.2. Previsões - Próxima semana

A atuação de áreas de instabilidade e o avanço de duas frentes frias, uma no início da semana avançando pelas regiões Sudeste e sul do litoral do Nordeste e a segunda pelo Sul e Sudeste no final da semana operativa, provocam precipitação nas principais bacias do SIN. Os maiores acumulados previstos são para a bacia do rio Paranaíba e para os trechos médio e alto das bacias dos rios Tocantins e São Francisco (Figura 2).

Figura 2 - Precipitação acumulada prevista pelo modelo ECMWF – 19 a 25/10/2024

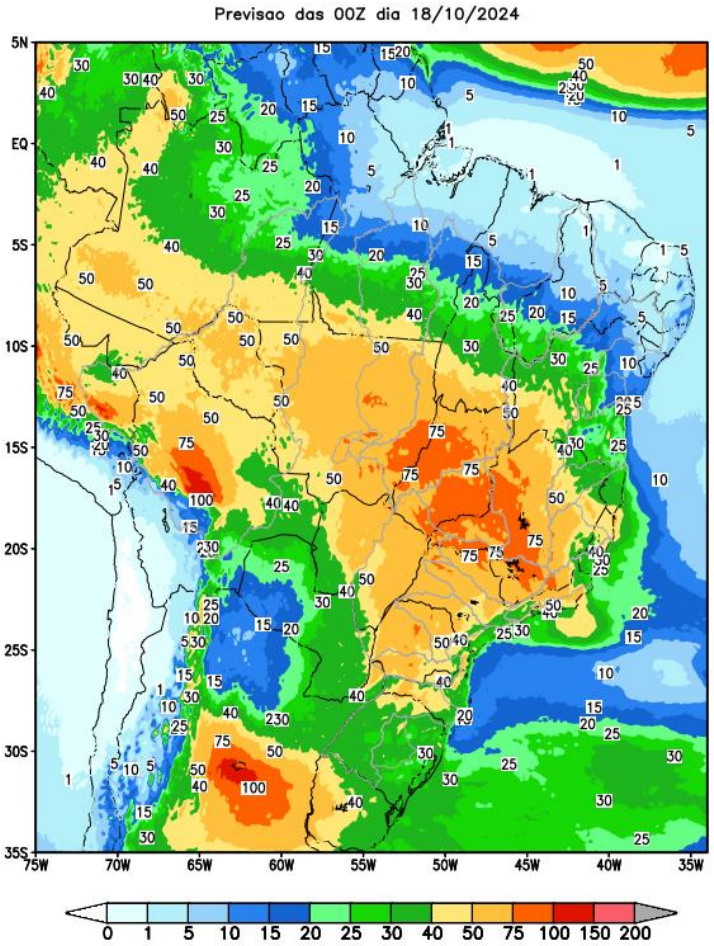

Em comparação com os valores estimados para a semana em curso, prevê-se para a próxima semana operativa ascensão nas afluências dos subsistemas Sudeste/Centro-Oeste, Nordeste e Norte e recessão nas afluências do subsistema Sul. A previsão mensal para outubro indica a ocorrência de afluências abaixo da média histórica para todos os subsistemas.

Tabela 2 – Previsão de ENAs da Revisão 3 de Outubro/2024

Revisão 3 do PMO de Outubro/2024 - ENAs previstas				
Subsistema	19/10 a 25/10/2024		Mês de outubro	
	MWmed	%MLT	MWmed	%MLT
SE/CO	18.940	80	13.762	58
S	7.544	56	10.302	77
NE	1.336	42	1.358	43
N	2.198	92	1.386	58

O conteúdo desta publicação foi produzido pelo ONS com base em dados e informações de conhecimento público. É de responsabilidade exclusiva dos agentes e demais interessados a obtenção de outros dados e informações, a realização de análises, estudos e avaliações para fins de tomada de decisões, definição de estratégias de atuação, assunção de compromissos e obrigações e quaisquer outras finalidades, em qualquer tempo e sob qualquer condição. É proibida a reprodução ou utilização total ou parcial do presente sem a identificação da fonte.

As figuras a seguir ilustram as ENAs semanais verificadas e previstas para as Revisões 2 e 3 do PMO de Outubro/2024.

Figura 3 - Energias Naturais Afluentes ao Subsistema Sudeste/Centro-Oeste das Revisões 2 e 3 do PMO de Outubro/2024

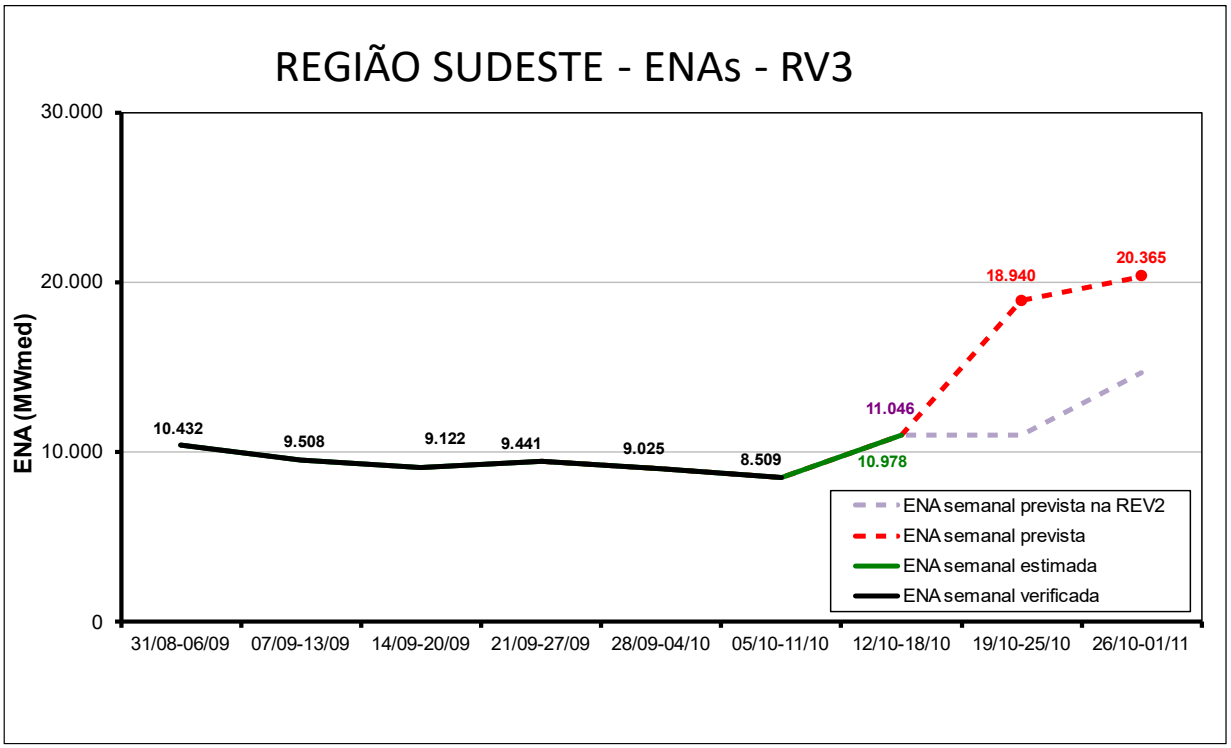

Figura 4 - Energias Naturais Afluentes ao Subsistema Sul das Revisões 2 e 3 do PMO de Outubro/2024

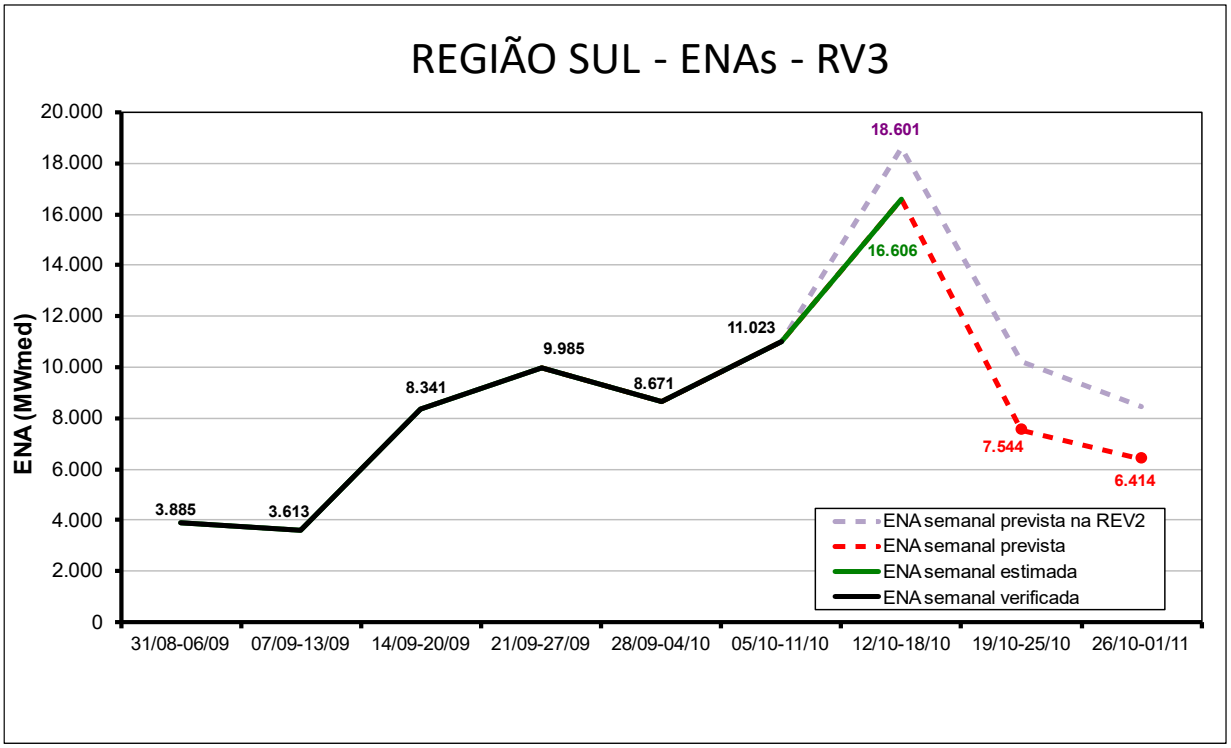

O conteúdo desta publicação foi produzido pelo ONS com base em dados e informações de conhecimento público. É de responsabilidade exclusiva dos agentes e demais interessados a obtenção de outros dados e informações, a realização de análises, estudos e avaliações para fins de tomada de decisões, definição de estratégias de atuação, assunção de compromissos e obrigações e quaisquer outras finalidades, em qualquer tempo e sob qualquer condição. É proibida a reprodução ou utilização total ou parcial do presente sem a identificação da fonte.

Figura 5 - Energias Naturais Afluentes ao Subsistema Nordeste das Revisões 2 e 3 do PMO de Outubro/2024

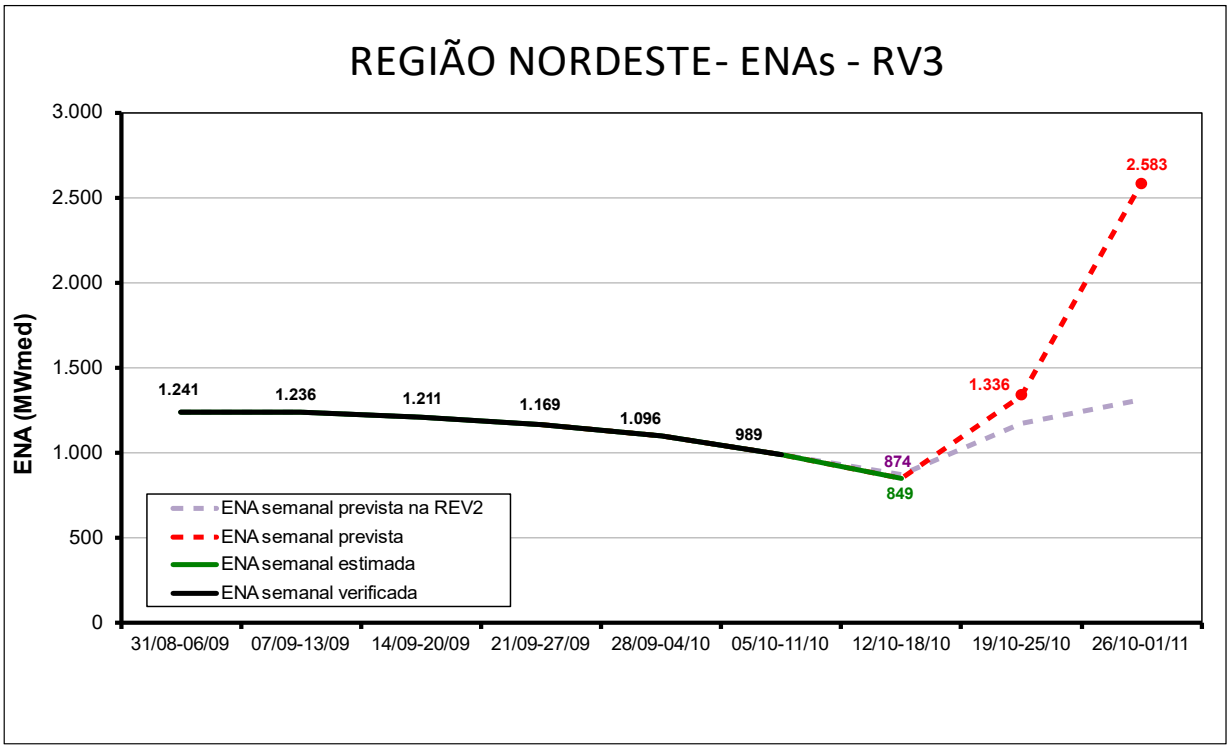

Figura 6 - Energias Naturais Afluentes ao Subsistema Norte das Revisões 2 e 3 do PMO de Outubro/2024

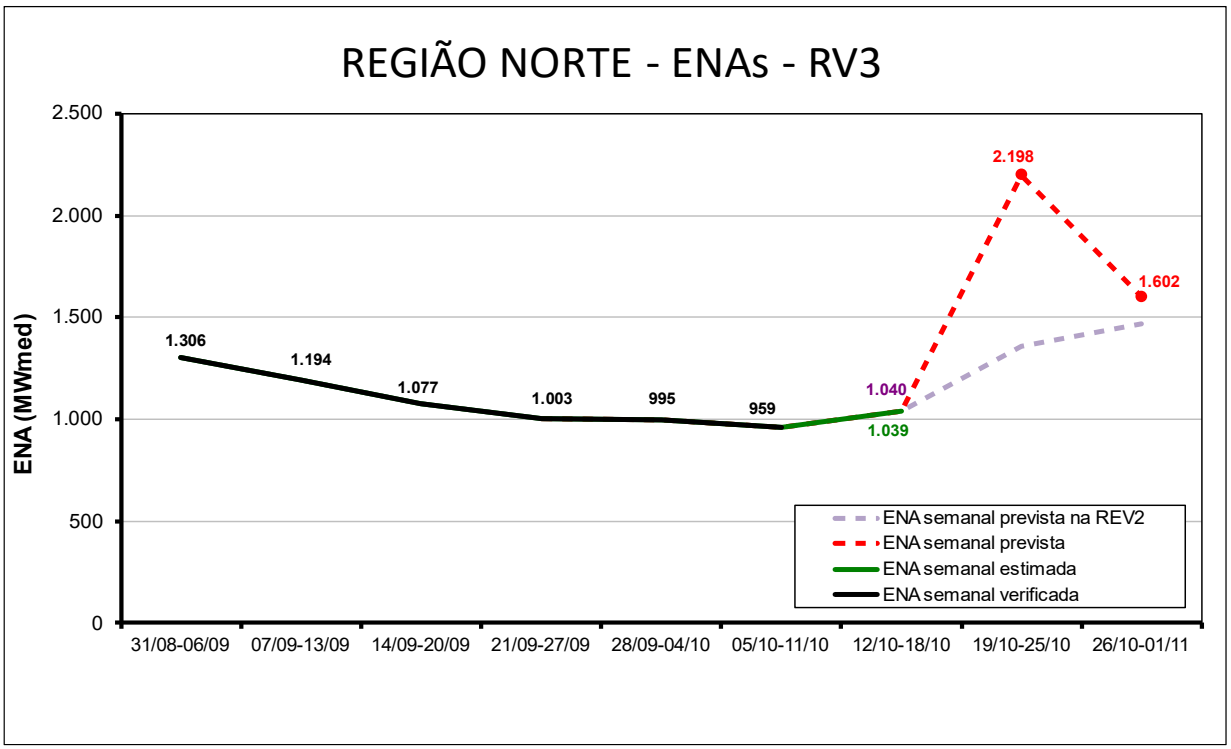

O conteúdo desta publicação foi produzido pelo ONS com base em dados e informações de conhecimento público. É de responsabilidade exclusiva dos agentes e demais interessados a obtenção de outros dados e informações, a realização de análises, estudos e avaliações para fins de tomada de decisões, definição de estratégias de atuação, assunção de compromissos e obrigações e quaisquer outras finalidades, em qualquer tempo e sob qualquer condição. É proibida a reprodução ou utilização total ou parcial do presente sem a identificação da fonte.

3.1.3. Cenários de ENAs para a Revisão 3 de Outubro/2024

As figuras a seguir apresentam as características dos cenários de energias naturais afluentes gerados na Revisão 3 de Outubro/2024, para acoplamento com a FCF do mês de novembro/2024. São mostradas, para os quatro subsistemas, as amplitudes e as Funções de Distribuição Acumulada dos cenários de ENA, comparativamente com os valores considerados para as revisões anteriores do PMO de Outubro/2024.

Figura 7 - Amplitude dos Cenários de ENA para o Subsistema Sudeste/Centro-Oeste, em %MLT, para a Revisão 3 de Outubro/2024

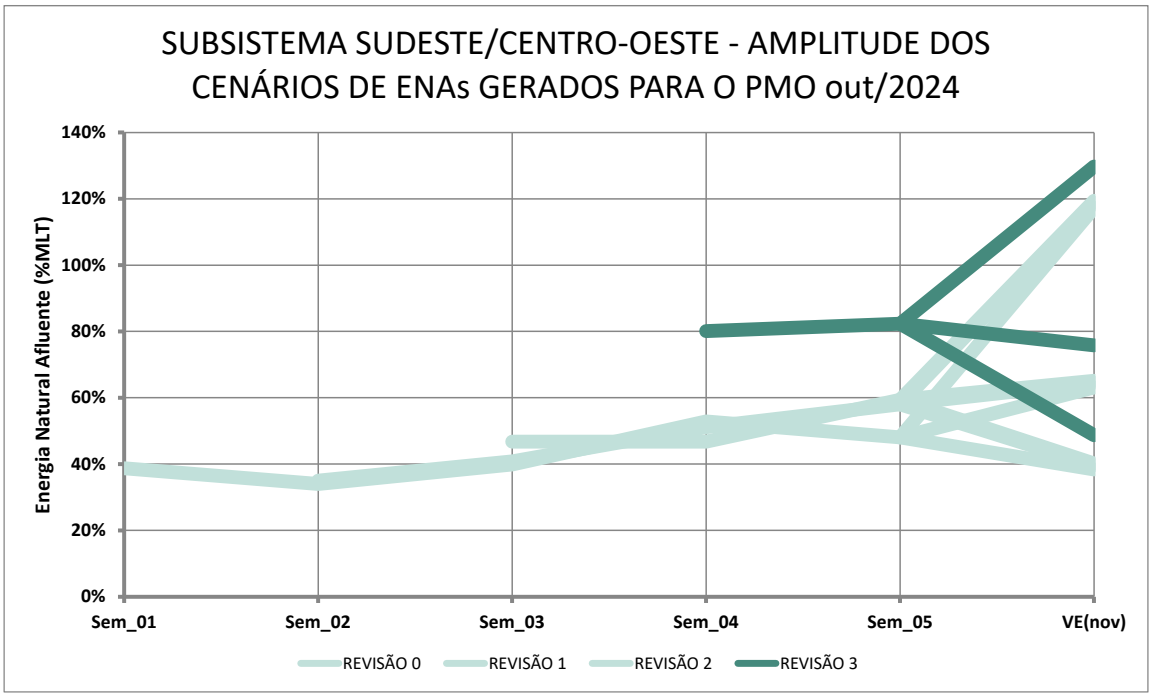

Figura 8 - Função de Distribuição Acumulada dos Cenários para o Subsistema Sudeste/Centro-Oeste para a Revisão 3 de Outubro/2024

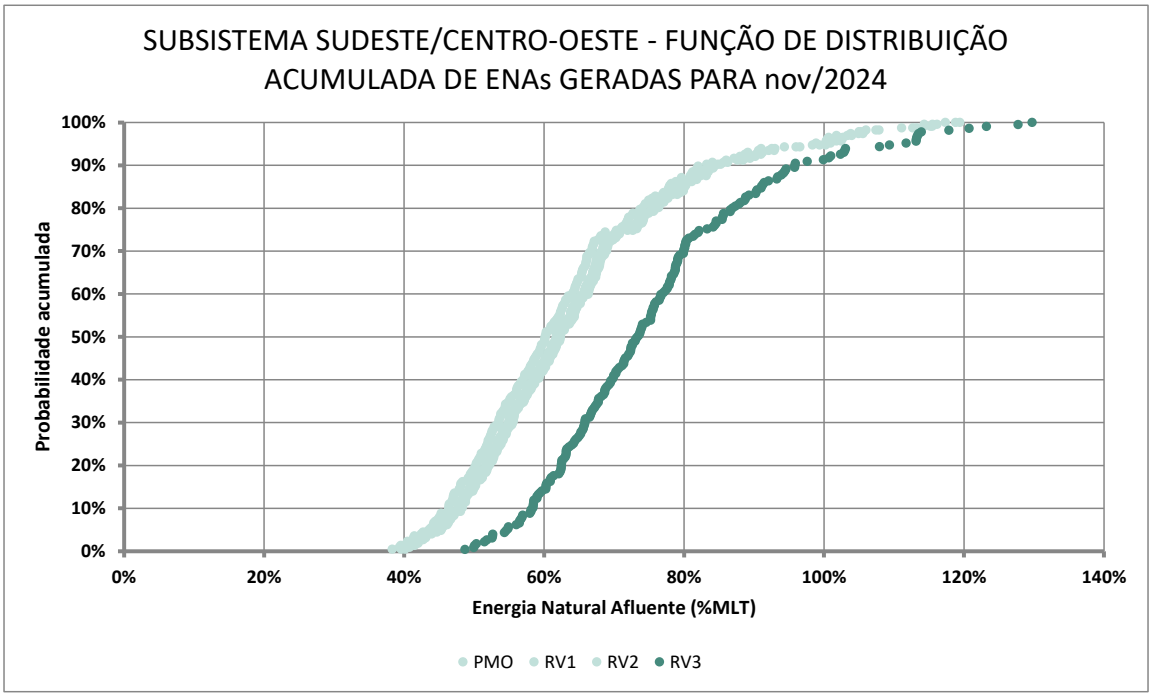

O conteúdo desta publicação foi produzido pelo ONS com base em dados e informações de conhecimento público. É de responsabilidade exclusiva dos agentes e demais interessados a obtenção de outros dados e informações, a realização de análises, estudos e avaliações para fins de tomada de decisões, definição de estratégias de atuação, assunção de compromissos e obrigações e quaisquer outras finalidades, em qualquer tempo e sob qualquer condição. É proibida a reprodução ou utilização total ou parcial do presente sem a identificação da fonte.

Figura 9 - Amplitude dos Cenários de ENA para o Subsistema Sul, em %MLT, para a Revisão 3 de Outubro/2024

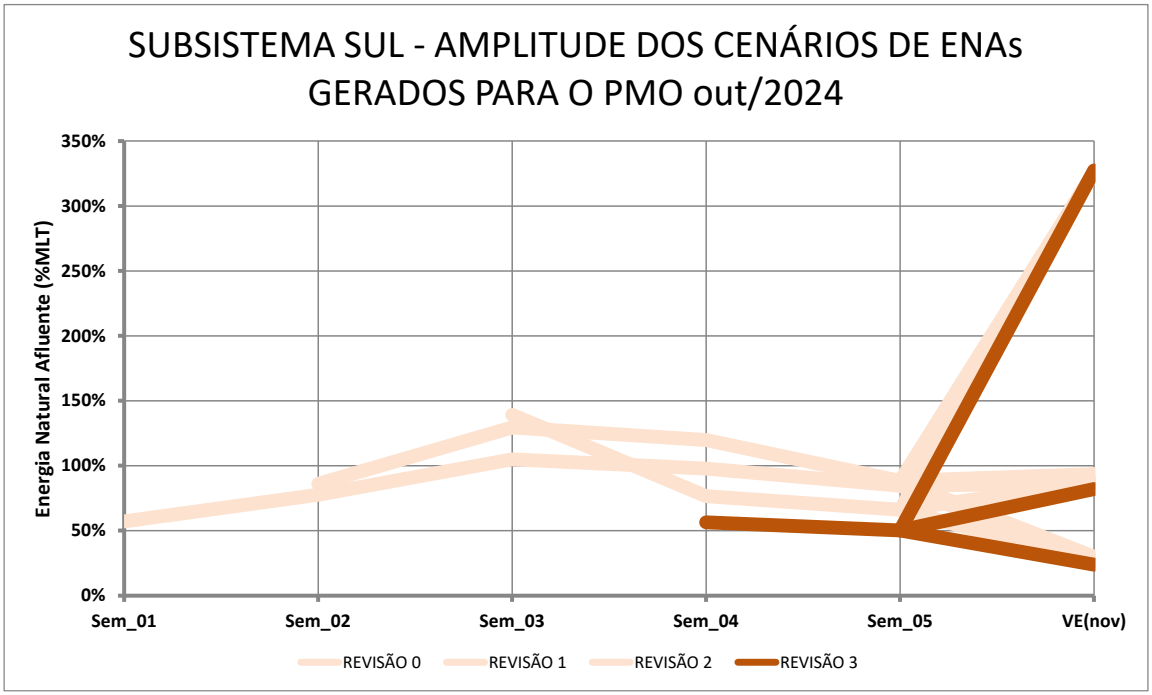

Figura 10 - Função de Distribuição Acumulada dos Cenários para o Subsistema Sul para a Revisão 3 de Outubro/2024

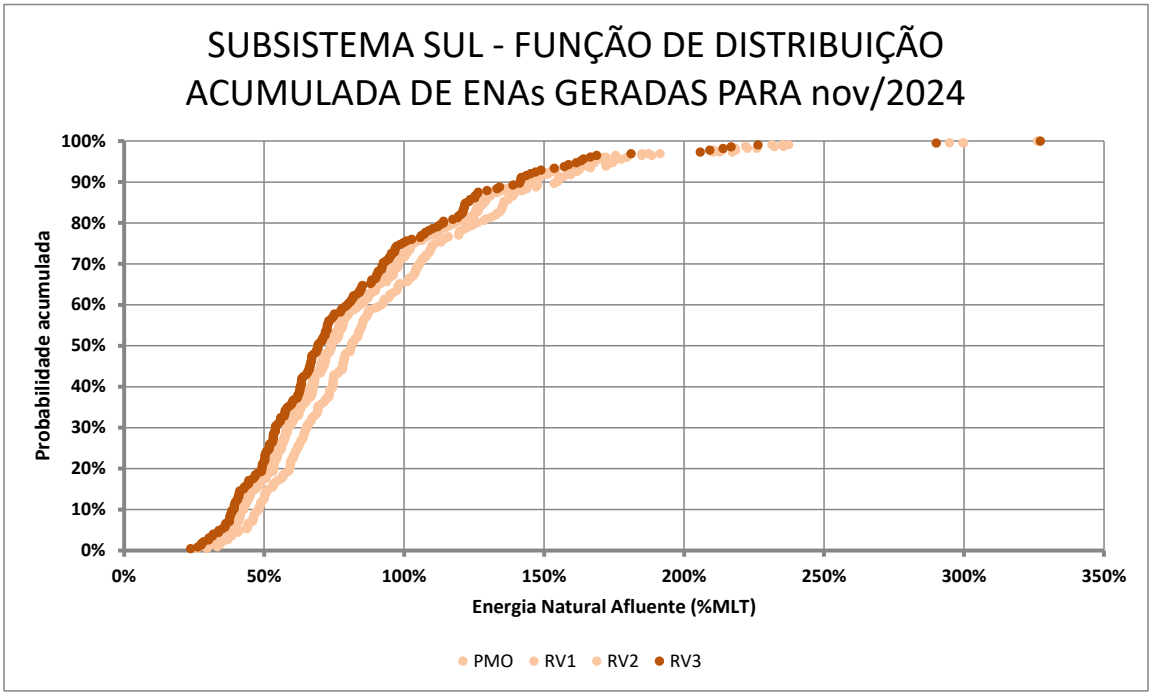

O conteúdo desta publicação foi produzido pelo ONS com base em dados e informações de conhecimento público. É de responsabilidade exclusiva dos agentes e demais interessados a obtenção de outros dados e informações, a realização de análises, estudos e avaliações para fins de tomada de decisões, definição de estratégias de atuação, assunção de compromissos e obrigações e quaisquer outras finalidades, em qualquer tempo e sob qualquer condição. É proibida a reprodução ou utilização total ou parcial do presente sem a identificação da fonte.

Figura 11 - Amplitude dos Cenários de ENA para o Subsistema Nordeste em %MLT, para a Revisão 3 de Outubro/2024

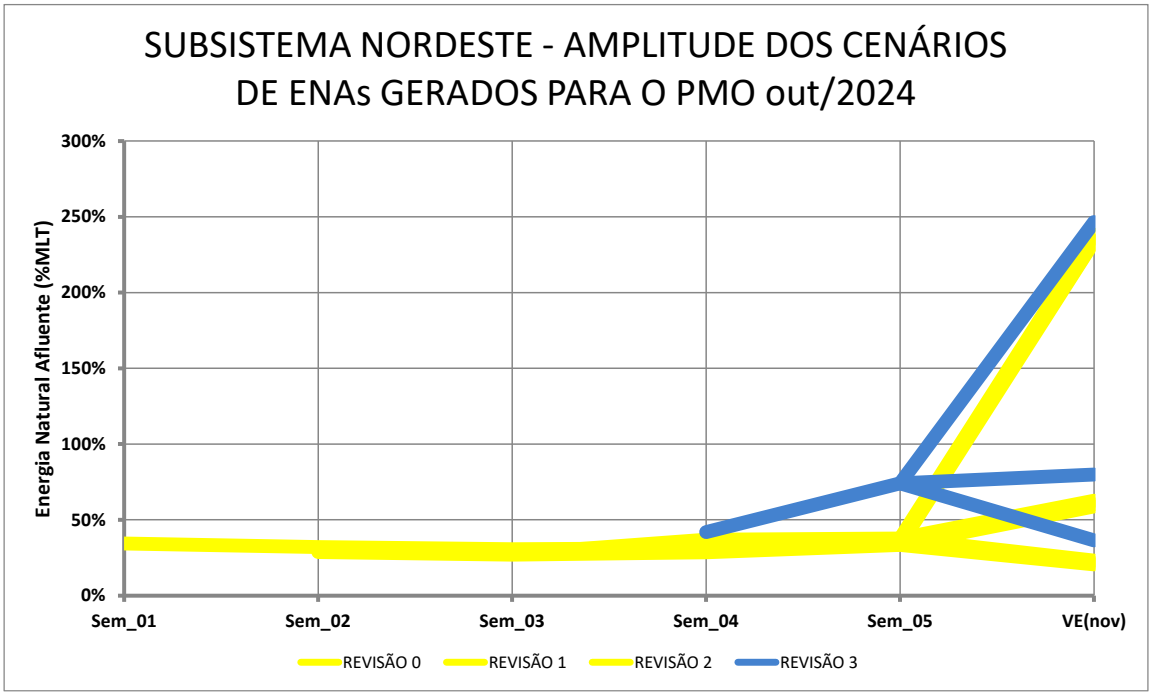

Figura 12 - Função de Distribuição Acumulada dos Cenários para o Subsistema Nordeste para a Revisão 3 de Outubro/2024

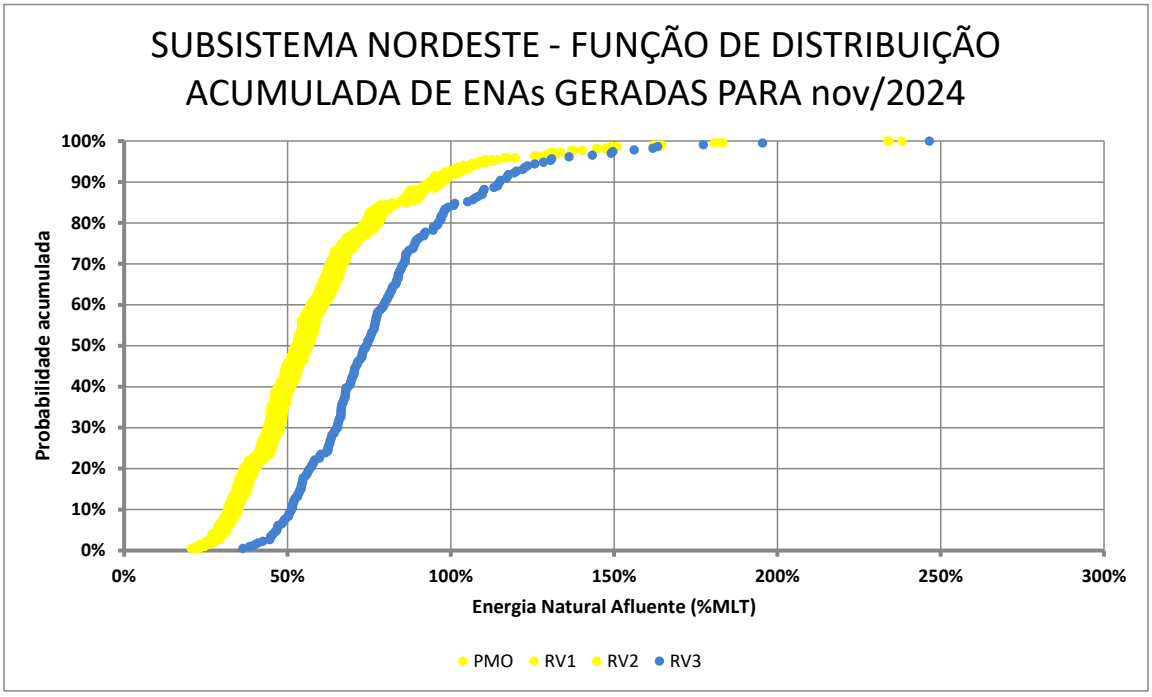

O conteúdo desta publicação foi produzido pelo ONS com base em dados e informações de conhecimento público. É de responsabilidade exclusiva dos agentes e demais interessados a obtenção de outros dados e informações, a realização de análises, estudos e avaliações para fins de tomada de decisões, definição de estratégias de atuação, assunção de compromissos e obrigações e quaisquer outras finalidades, em qualquer tempo e sob qualquer condição. É proibida a reprodução ou utilização total ou parcial do presente sem a identificação da fonte.

Figura 13 - Amplitude dos Cenários de ENA para o Subsistema Norte, em %MLT, para a Revisão 3 de Outubro/2024

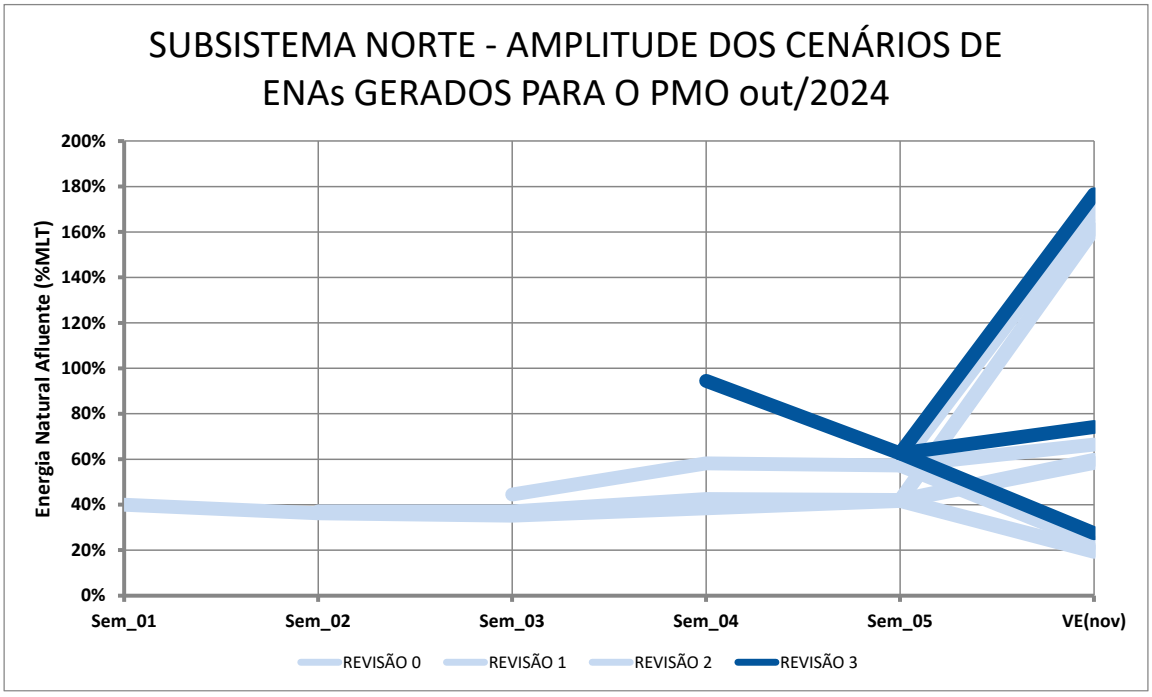

Figura 14 - Função de Distribuição Acumulada dos Cenários para o Subsistema Norte para a Revisão 3 de Outubro/2024

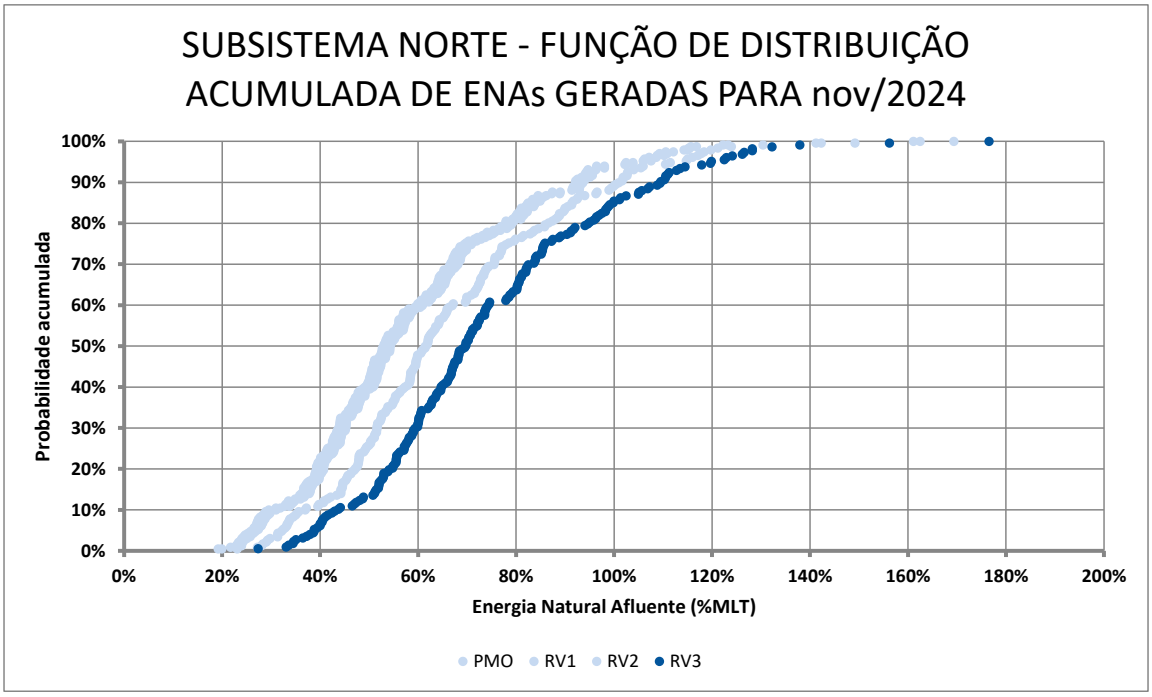

O conteúdo desta publicação foi produzido pelo ONS com base em dados e informações de conhecimento público. É de responsabilidade exclusiva dos agentes e demais interessados a obtenção de outros dados e informações, a realização de análises, estudos e avaliações para fins de tomada de decisões, definição de estratégias de atuação, assunção de compromissos e obrigações e quaisquer outras finalidades, em qualquer tempo e sob qualquer condição. É proibida a reprodução ou utilização total ou parcial do presente sem a identificação da fonte.

Os valores da MLT (Média de Longo Termo) das energias naturais afluentes para os meses de outubro/2024 e novembro/2024 são apresentados na tabela a seguir.

Tabela 3 – MLT da ENA nos meses de outubro/2024 e novembro/2024

MLT das ENAs (MWmed)		
Subsistema	**outubro**	**novembro**
SE/CO	23.653	31.416
S	13.360	9.311
NE	3.189	5.279
N	2.383	4.063

3.2. Limites de Intercâmbio entre Subsistemas

Os limites elétricos de intercâmbio de energia entre subsistemas são de fundamental importância para o processo de otimização energética, sendo determinantes para a definição das políticas de operação e do CMO para cada subsistema. Estes limites são influenciados por intervenções na malha de transmissão, notadamente na primeira semana operativa. O diagrama a seguir ilustra os fluxos notáveis do SIN e os limites aplicados neste PMO.

Figura 15 – Interligações entre regiões

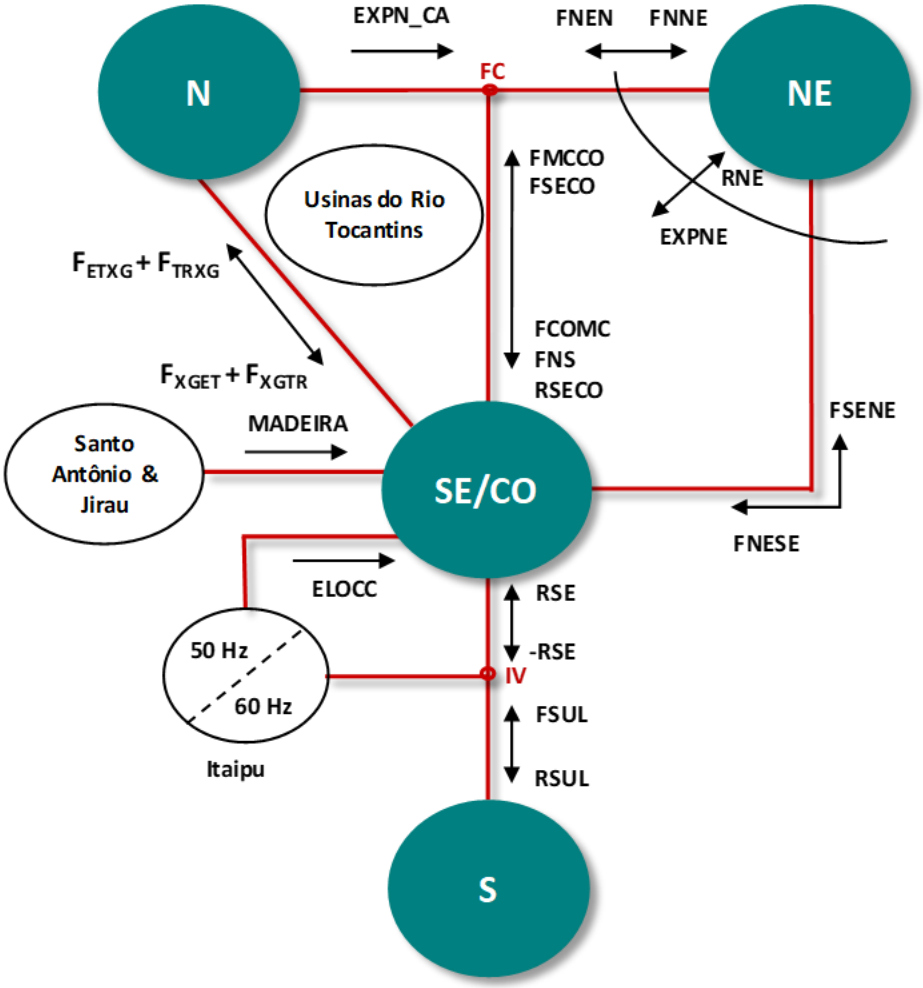

O conteúdo desta publicação foi produzido pelo ONS com base em dados e informações de conhecimento público. É de responsabilidade exclusiva dos agentes e demais interessados a obtenção de outros dados e informações, a realização de análises, estudos e avaliações para fins de tomada de decisões, definição de estratégias de atuação, assunção de compromissos e obrigações e quaisquer outras finalidades, em qualquer tempo e sob qualquer condição. É proibida a reprodução ou utilização total ou parcial do presente sem a identificação da fonte.

Tabela 4 – Limites considerados nesta semana operativa para intercâmbio de energia

Limites de Intercâmbio (MWmed)				
Fluxo	Patamar	19/10 a 25/10/2024		Demais Semanas
RNE	Pesada	11.000		11.000
	Média	11.000		11.000
	Leve	11.000		11.000
FNS	Pesada	5.100		5.100
	Média	5.100		5.100
	Leve	4.900		4.900
FNNE	Pesada	7.800		7.800
	Média	**7.683**	(A) (B)	7.800
	Leve	**7.020**		7.800
EXPORT. NE	Pesada	11.600		11.600
	Média	11.600		11.600
	Leve	11.600		11.600
FMCCO	Pesada	5.000		5.000
	Média	5.000		5.000
	Leve	5.000		5.000
FSENE	Pesada	6.000		6.000
	Média	6.000		6.000
	Leve	6.000		6.000
FNS + FNESE	Pesada	11.100		11.100
	Média	11.100		11.100
	Leve	11.100		11.100
RSE	Pesada	9.800		9.800
	Média	9.800		9.800
	Leve	10.900		10.900
FORNEC. SUL	Pesada	7.000		7.000
	Média	7.000		7.000
	Leve	8.600		8.600

Limites de Intercâmbio (MWmed)				
Fluxo	Patamar	19/10 a 25/10/2024		Demais Semanas
RECEB. SUL	Pesada	10.114		10.114
	Média	8.314		8.314
	Leve	10.914		10.914
ELO CC 50 Hz	Pesada	**4.796**		5.481
	Média	**4.861**		5.481
	Leve	**5.158**		5.481
ITAIPU 60 Hz	Pesada	7.500		7.500
	Média	7.500		7.500
	Leve	7.500		7.500
EXP. N CA	Pesada	8.000		8.000
	Média	8.000		8.000
	Leve	8.000		8.000
FETXG + FTRXG	Pesada	4.200		4.200
	Média	1.000		1.000
	Leve	1.000		1.000
FXGET + FXGTR	Pesada	3.000		3.000
	Média	3.000	(C)	3.000
	Leve	**2.850**		3.000
FNESE	Pesada	8.300		8.300
	Média	**8.246**	(A) (B)	8.300
	Leve	**7.858**		8.300
FNEN	Pesada	4.800		4.800
	Média	4.800	(B)	4.800
	Leve	**4.680**		4.800
Ger_MADEIRA	Pesada	**6.650**	(D) (E) (F) (G)	7.000
	Média	**6.191**		7.000
	Leve	**6.099**		7.000

(A) SGI 60.029-24
(B) SGI 58.056-24
(C) SGI 59.619-24
(D) SGI 59.705-24
(E) SGI 58.694-24
(F) SGI 60.385-24
(G) MOP/ONS 476-S/2024

O conteúdo desta publicação foi produzido pelo ONS com base em dados e informações de conhecimento público. É de responsabilidade exclusiva dos agentes e demais interessados a obtenção de outros dados e informações, a realização de análises, estudos e avaliações para fins de tomada de decisões, definição de estratégias de atuação, assunção de compromissos e obrigações e quaisquer outras finalidades, em qualquer tempo e sob qualquer condição. É proibida a reprodução ou utilização total ou parcial do presente sem a identificação da fonte.

3.3. Previsão de carga

O cenário econômico recente mostra uma leve retração em alguns setores, como observado no Monitor do PIB da FGV. Em agosto de 2024, a atividade econômica caiu 0,2% em relação a julho, com um crescimento interanual de 3,4%. No trimestre móvel até agosto, houve uma expansão de 4,1%. Esse desempenho foi impulsionado, em grande parte, pelo consumo das famílias, que apresentou crescimento disseminado nos diferentes tipos de consumo, destacando-se o consumo de serviços. No entanto, a indústria permaneceu estagnada, enquanto os serviços recuaram ligeiramente. No setor de investimentos, a Formação Bruta de Capital Fixo (FBCF) cresceu 7,5% no trimestre, impulsionada principalmente pela aquisição de máquinas e equipamentos, o que reflete a recuperação pós-pandemia. A exportação, por sua vez, recuou 2,5%, afetada pela queda nos produtos agropecuários e da extrativa mineral.

A semana em curso se iniciou com a passagem de uma frente fria pelo litoral do Paraná e pela região Sudeste, provocando precipitação especialmente em São Paulo. Para a próxima semana, as sinalizações meteorológicas para as regiões Sudeste, Centro-Oeste e Sul indicam temperaturas mais amenas nos primeiros dias, em relação ao comportamento da semana atual, com elevação gradual ao longo do período. Outro destaque é a expectativa de um acumulado de precipitação superior ao observado na semana em curso, porém sem a ocorrência de chuvas tão fortes quanto as observadas principalmente em São Paulo.

Para os subsistemas Norte e Nordeste, as projeções meteorológicas não indicam mudanças significativas de temperaturas para a próxima semana. Destaca-se a sinalização de ocorrência de precipitação ao longo da semana em Salvador e em Recife, superior à observada no período atual, além da expectativa de pancadas de chuva em Manaus.

Assim, os novos valores de carga previstos para o mês de outubro/2024, indicam crescimentos de 2,5% no subsistema Sudeste/Centro-Oeste, 3,3% no subsistema Sul, 4,3% no subsistema Nordeste e 8,5% no subsistema Norte.

Tabela 5 – Evolução da carga do PMO de Outubro de 2024

Subsistema	CARGA SEMANAL (MWmed)					CARGA MENSAL (MWmed)	
	1ª Sem	2ª Sem	3ª Sem	4ª Sem	5ª Sem	out/24	Var. (%) out/24 -> out/23
SE/CO	47.010	45.874	44.585	45.975	46.232	45.822	2,5%
S	13.570	13.199	12.817	13.153	13.337	13.177	3,3%
NE	13.808	14.005	13.802	13.865	13.888	13.879	4,3%
N	8.399	8.433	8.272	8.383	8.463	8.387	8,5%
SIN	**82.787**	**81.511**	**79.476**	**81.377**	**81.919**	**81.265**	**3,5%**

O conteúdo desta publicação foi produzido pelo ONS com base em dados e informações de conhecimento público. É de responsabilidade exclusiva dos agentes e demais interessados a obtenção de outros dados e informações, a realização de análises, estudos e avaliações para fins de tomada de decisões, definição de estratégias de atuação, assunção de compromissos e obrigações e quaisquer outras finalidades, em qualquer tempo e sob qualquer condição. É proibida a reprodução ou utilização total ou parcial do presente sem a identificação da fonte.

3.4. Potência Hidráulica Total Disponível no SIN

O gráfico a seguir mostra a disponibilidade hidráulica total do SIN, para este mês, de acordo com o cronograma de manutenção informado pelos agentes para esta Revisão.

Figura 16 – Potência hidráulica disponível no SIN

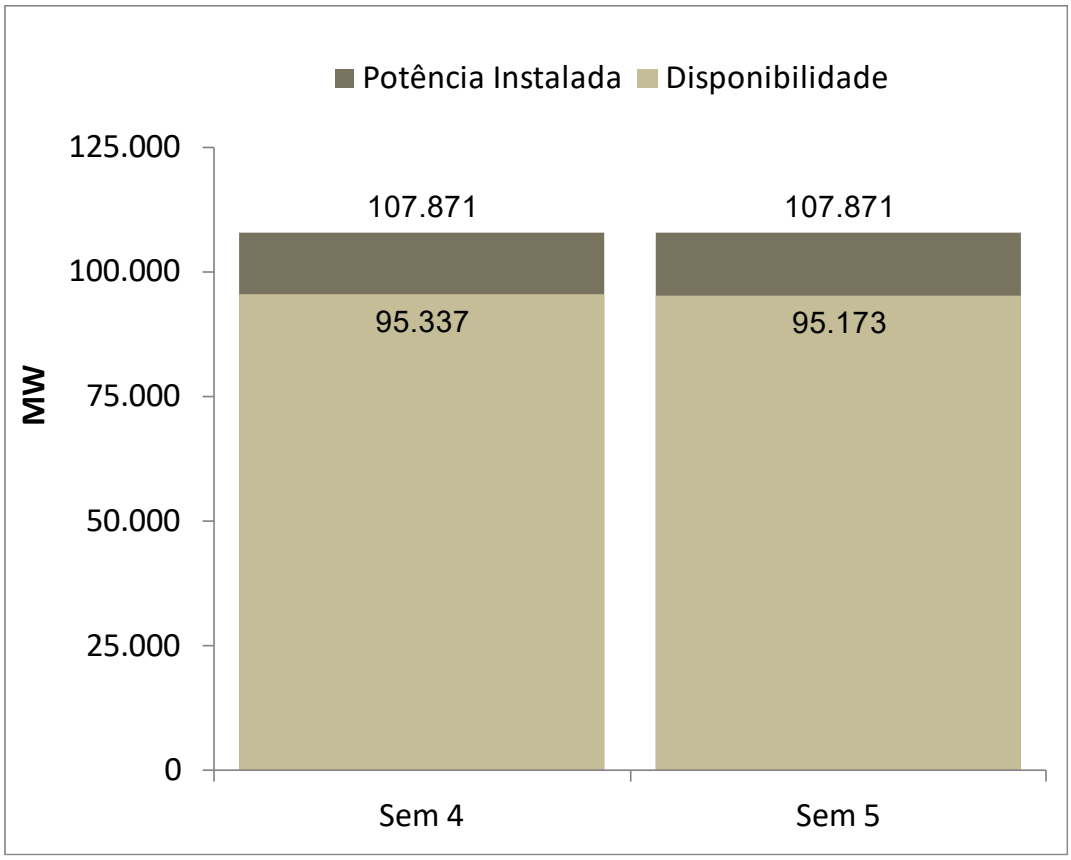

3.5. Armazenamentos Iniciais por Subsistema

Tabela 6 – Armazenamentos iniciais, por subsistema, considerados para esta semana operativa

Armazenamento (%EARmáx) - 0:00 h do dia 19/10/2024		
Subsistema	Nível previsto na Revisão 2 do PMO Out/2024	Partida informada pelos Agentes para a Revisão 3 do PMO Out/2024
SE/CO	41,3	41,1
S	63,7	65,8
NE	46,3	45,9
N	67,4	67,7

A primeira coluna da tabela acima corresponde ao armazenamento previsto na Revisão 2 do PMO de Outubro de 2024, para a 0:00 h do dia 19/10/2024. A segunda coluna apresenta os armazenamentos obtidos a partir dos níveis de partida informados pelos Agentes de Geração para seus aproveitamentos com reservatórios.

O conteúdo desta publicação foi produzido pelo ONS com base em dados e informações de conhecimento público. É de responsabilidade exclusiva dos agentes e demais interessados a obtenção de outros dados e informações, a realização de análises, estudos e avaliações para fins de tomada de decisões, definição de estratégias de atuação, assunção de compromissos e obrigações e quaisquer outras finalidades, em qualquer tempo e sob qualquer condição. É proibida a reprodução ou utilização total ou parcial do presente sem a identificação da fonte.

4. PRINCIPAIS RESULTADOS

4.1. Política de Operação Energética

Para esta semana operativa, está prevista a seguinte política de intercâmbio de energia entre regiões:

Região SE/CO:

- Utilização dos recursos das bacias dos rios Grande, Paranaíba e Paraná, conforme necessidade de alocação na carga média e pesada e controle de nível;
- Minimização dos recursos do Tietê e Paranapanema para evitar impacto em restrições de operação;
- Minimização na utilização dos recursos das usinas do AC/RO.

Região Sul:

- Exploração da geração hidráulica condicionada à disponibilidade dos demais recursos disponíveis no SIN, bem como à variação da carga, e buscando a preservação dos recursos em reservatórios que já apresentam níveis reduzidos.

Região NE:

- Em atendimento à resolução 2081/2017 da ANA, Sobradinho está operando na faixa de atenção, limitando a máxima defluência média mensal da UHE Xingó em 1.000 m³/s. Dessa forma, serão praticadas modulações de geração para atendimento à carga, respeitando a média mensal limite;
- Perfil exportador de energia em todos os patamares de carga devido EOL/UFV.

Região Norte:

- Utilização da geração da usina de Belo Monte para atendimento à ponta de carga, conforme disponibilidade energética;
- Exploração da geração das usinas da bacia do rio Tocantins para atendimento à ponta de carga;
- Operação minimizada nas demais usinas do Norte.

4.2. Custo Marginal de Operação – CMO

A figura a seguir apresenta os Custos Marginais de Operação, em valores médios semanais, para as semanas operativas deste mês.

Figura 17 – CMO em valores médios

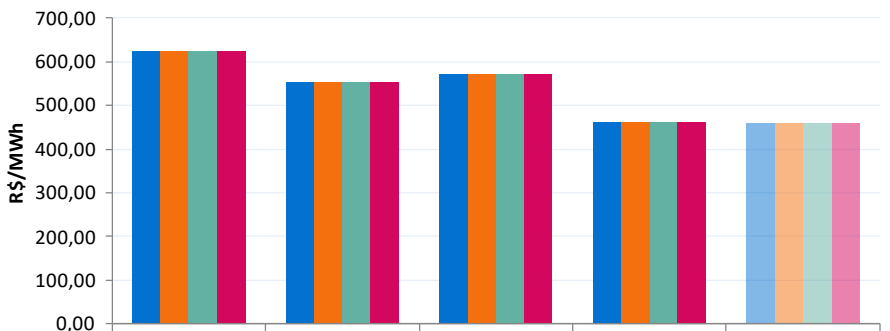

	Sem1	Sem2	Sem3	Sem4	Sem5
Sudeste	624,81	552,40	571,67	460,62	459,35
Sul	624,81	552,40	571,67	460,62	459,35
Nordeste	624,81	552,40	571,67	460,62	459,35
Norte	624,81	552,40	571,67	460,62	459,35

O conteúdo desta publicação foi produzido pelo ONS com base em dados e informações de conhecimento público. É de responsabilidade exclusiva dos agentes e demais interessados a obtenção de outros dados e informações, a realização de análises, estudos e avaliações para fins de tomada de decisões, definição de estratégias de atuação, assunção de compromissos e obrigações e quaisquer outras finalidades, em qualquer tempo e sob qualquer condição. É proibida a reprodução ou utilização total ou parcial do presente sem a identificação da fonte.

A tabela a seguir apresenta o custo marginal de operação, por subsistema e patamar de carga, para a próxima semana operativa.

Tabela 7 – CMO para esta semana operativa

Patamares de Carga	CMO (R$/MWh)			
	SE/CO	S	NE	N
Pesada	475,58	475,58	475,58	475,58
Média	463,62	463,62	463,62	463,62
Leve	451,34	451,34	451,34	451,34
Média Semanal	460,62	460,62	460,62	460,62

4.3. Energia Armazenada

O processo de otimização realizado pelo programa DECOMP indicou os armazenamentos mostrados na figura a seguir para as próximas semanas operativas do mês de outubro/2024.

Figura 18 – Energias Armazenadas nas semanas operativas do mês de outubro/2024 por subsistema.

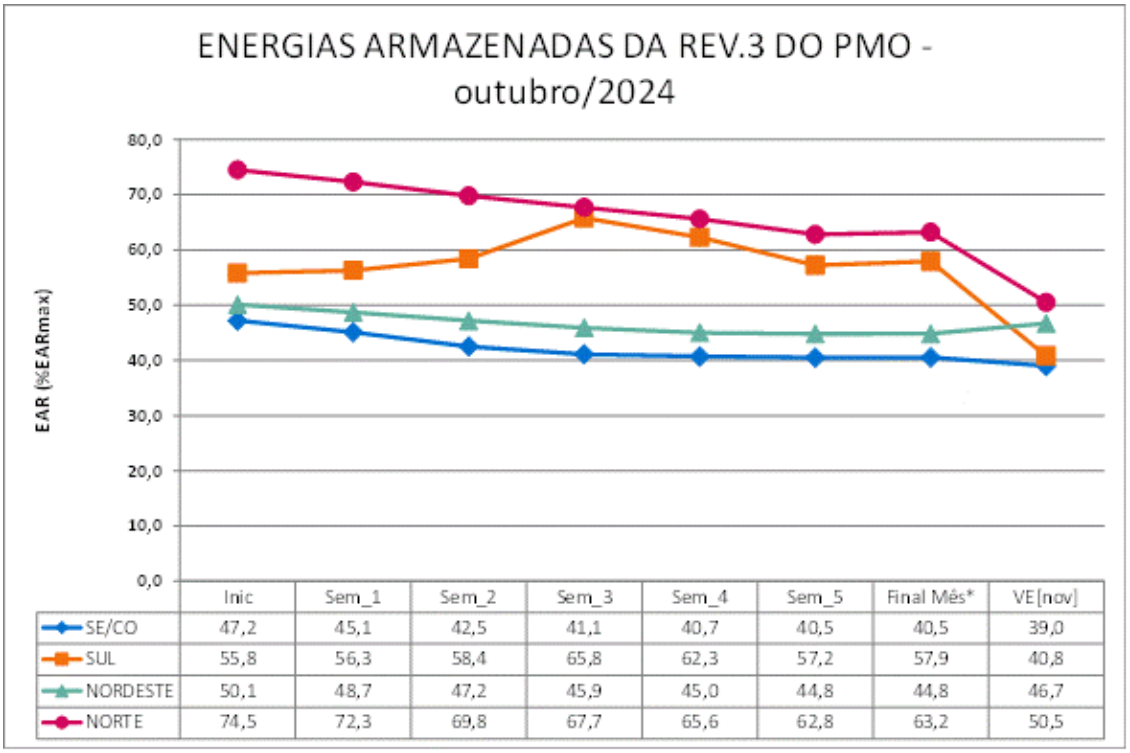

Os armazenamentos da figura anterior estão expressos em percentual da Energia Armazenável Máxima de cada subsistema, que são mostradas na tabela a seguir.

Tabela 8 – Energia Armazenável Máxima por subsistema no PMO de Outubro/2024.

ENERGIA ARMAZENÁVEL MÁXIMA (MWmed)		
Subsistema	outubro	novembro
SE/CO	205.460	205.460
S	20.458	20.458
NE	51.718	51.718
N	15.733	15.755

O conteúdo desta publicação foi produzido pelo ONS com base em dados e informações de conhecimento público. É de responsabilidade exclusiva dos agentes e demais interessados a obtenção de outros dados e informações, a realização de análises, estudos e avaliações para fins de tomada de decisões, definição de estratégias de atuação, assunção de compromissos e obrigações e quaisquer outras finalidades, em qualquer tempo e sob qualquer condição. É proibida a reprodução ou utilização total ou parcial do presente sem a identificação da fonte.

5. GERAÇÃO TÉRMICA

A Figura 19 apresenta, para cada subsistema do SIN, o despacho térmico por modalidade indicado pelo Decomp para esta semana operativa.

Figura 19 – Geração térmica para a próxima semana operativa

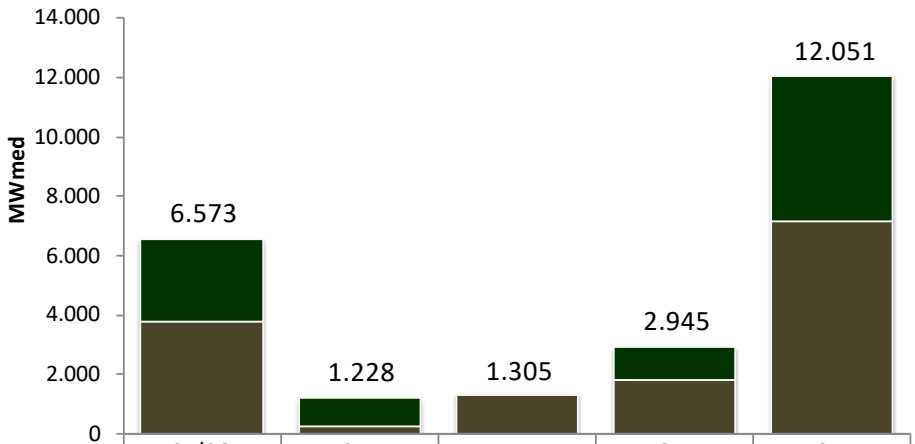

	SE/CO	SUL	NE	NORTE	SIN
TOTAL	6.573	1.228	1.305	2.945	12.051
RESTRIÇÃO ELÉTRICA	0	0	0	0	0
INFLEXIBILIDADE	2806	956	4	1150	4916
ORDEM DE MÉRITO	3767	272	1301	1795	7135

Na tabela abaixo segue a Indicação de despacho antecipado por ordem de mérito de custo para a semana de 21/12/2024 a 27/12/2024.

Tabela 9 – UTEs com contrato de combustível GNL

UTE			Benefício (R$/MWh)			Despacho antecipado por mérito		
Nome	Código	CVU (R$/MWh)	Carga Pesada	Carga Média	Carga Leve	Carga Pesada	Carga Média	Carga Leve
SANTA CRUZ	86	184,58	334,09	334,09	334,09	Sim	Sim	Sim
LUIZORMELO	15	276,35	334,09	334,09	334,09	Sim	Sim	Sim
PSERGIPE I	224	348,03	332,59	331,75	331,75	Não	Não	Não

Assim sendo, para a semana de 21/12/2024 a 27/12/2024, não há mais indicação de despacho antecipado por ordem de mérito para a UTE Porto Sergipe I, enquanto para as UTEs Santa Cruz e Luiz O. R. Melo a indicação de despacho segue mantida.

O conteúdo desta publicação foi produzido pelo ONS com base em dados e informações de conhecimento público. É de responsabilidade exclusiva dos agentes e demais interessados a obtenção de outros dados e informações, a realização de análises, estudos e avaliações para fins de tomada de decisões, definição de estratégias de atuação, assunção de compromissos e obrigações e quaisquer outras finalidades, em qualquer tempo e sob qualquer condição. É proibida a reprodução ou utilização total ou parcial do presente sem a identificação da fonte.

6. IMPORTAÇÃO DE ENERGIA

6.1. República Oriental do Uruguai

Para a próxima semana operativa, foram declaradas as seguintes ofertas de importação de energia da República Oriental do Uruguai para o SIN através da conversora de Melo (500 MW).

- **Enel**

Tabela 10 – Energia ofertada para importação

	Oferta de Energia para a Semana de 19/10 a 25/10 (MWmed)							
	Bloco 1	Bloco 2	Bloco 3	Bloco 4	Bloco 5	Bloco 6	Bloco 7	Total
Carga Pesada	33	33	33	17	17	17	17	167
Carga Média	33	33	33	17	17	17	17	167
Carga Leve	33	33	33	17	17	17	17	167
CVU (R$/MWh)	393,45	586,00	901,94	1.295,12	1.421,50	1.765,53	1.877,86	

- **BTG Pactual**

Tabela 11 – Energia ofertada para importação

	Oferta de Energia para a Semana de 19/10 a 25/10 (MWmed)							
	Bloco 1	Bloco 2	Bloco 3	Bloco 4	Bloco 5	Bloco 6	Bloco 7	Total
Carga Pesada	33	33	33	17	17	17	17	167
Carga Média	33	33	33	17	17	17	17	167
Carga Leve	33	33	33	17	17	17	17	167
CVU (R$/MWh)	397,95	598,04	919,60	1.319,77	1.448,39	1.798,54	1.912,87	

- **Bolt Energy**

Tabela 12 – Energia ofertada para importação

	Oferta de Energia para a Semana de 19/10 a 25/10 (MWmed)							
	Bloco 1	Bloco 2	Bloco 3	Bloco 4	Bloco 5	Bloco 6	Bloco 7	Total
Carga Pesada	33	33	33	17	17	17	17	167
Carga Média	33	33	33	17	17	17	17	167
Carga Leve	33	33	33	17	17	17	17	167
CVU (R$/MWh)	411,03	607,27	922,65	1.315,12	1.441,28	1.784,69	1.896,83	

6.2. República da Argentina

Para a próxima semana operativa, foi declarada oferta de importação de energia da República da Argentina para o SIN através das conversoras de Garabi 1 (1.100 MW) e Garabi 2 (1.100 MW).

- **Enel**

Tabela 13 – Energia ofertada para importação

	Oferta de Energia para a Semana de 19/10 a 25/10 (MWmed)				
	Bloco 1	Bloco 2	Bloco 3	Bloco 4	Total
Carga Pesada	300	1200	500	200	2200
Carga Média	300	1200	500	200	2200
Carga Leve	300	1200	500	200	2200
CVU (R$/MWh)	661,62	798,04	1.144,32	1.422,79	

Nota: Detalhes sobre a importação de energia vide Portaria Normativa Nº 60/GM/MME, de 29 de dezembro de 2022 disponível em: https://www.in.gov.br/en/web/dou/-/portaria-normativa-n-60/gm/mme-de-29-de-dezembro-de-2022-454963353

O conteúdo desta publicação foi produzido pelo ONS com base em dados e informações de conhecimento público. É de responsabilidade exclusiva dos agentes e demais interessados a obtenção de outros dados e informações, a realização de análises, estudos e avaliações para fins de tomada de decisões, definição de estratégias de atuação, assunção de compromissos e obrigações e quaisquer outras finalidades, em qualquer tempo e sob qualquer condição. É proibida a reprodução ou utilização total ou parcial do presente sem a identificação da fonte.

7. RESUMO DOS RESULTADOS DO PMO

As figuras a seguir apresentam um resumo dos resultados da Revisão 3 de Outubro/2024, com informações da Energia Natural Afluente (ENA), da Energia Armazenada (EAR) e do Custo Marginal de Operação (CMO) nos subsistemas do Sistema Interligado Nacional (SIN). São apresentados os valores semanais observados e previstos e o valor esperado dos cenários gerados para o mês de novembro/2024.

Figura 20 – Resumo de outubro/2024 para o Subsistema Sudeste/Centro-Oeste

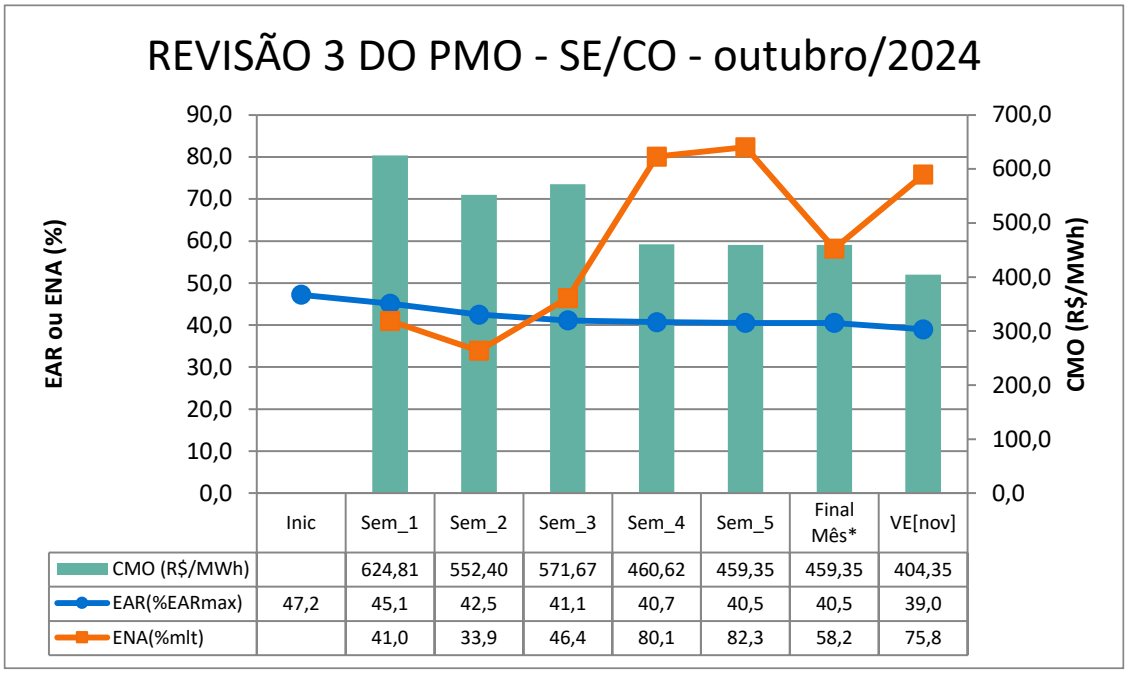

	Inic	Sem_1	Sem_2	Sem_3	Sem_4	Sem_5	Final Mês*	VE[nov]
CMO (R$/MWh)		624,81	552,40	571,67	460,62	459,35	459,35	404,35
EAR(%EARmax)	47,2	45,1	42,5	41,1	40,7	40,5	40,5	39,0
ENA(%mlt)		41,0	33,9	46,4	80,1	82,3	58,2	75,8

Figura 21 – Resumo de outubro/2024 para o Subsistema Sul

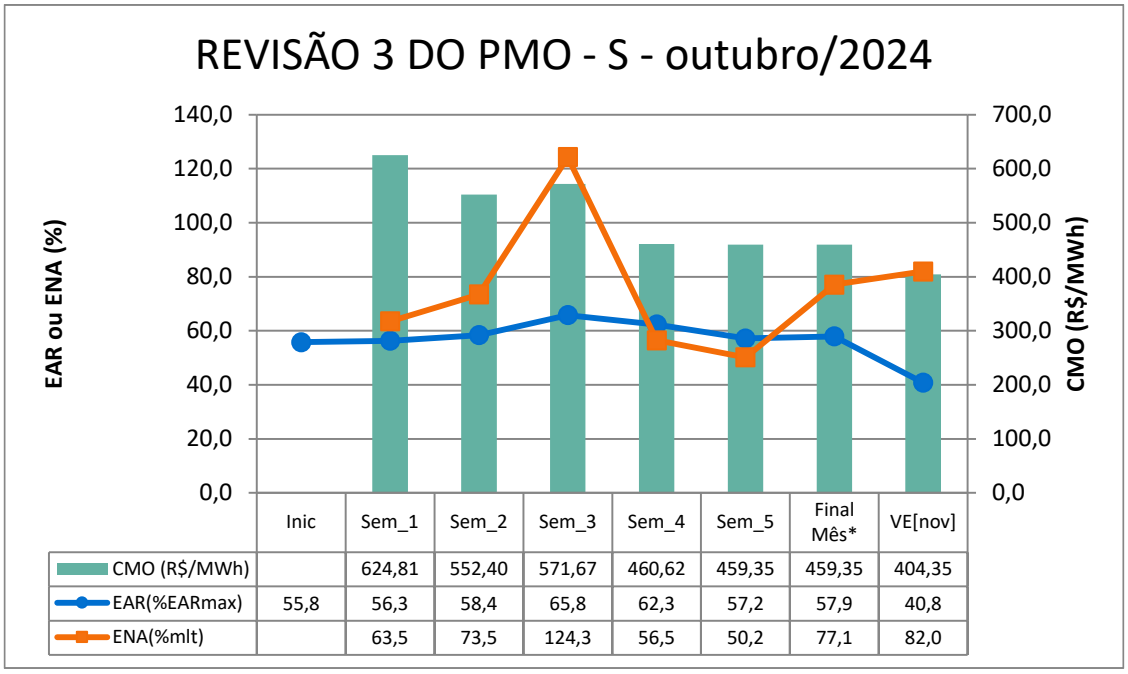

	Inic	Sem_1	Sem_2	Sem_3	Sem_4	Sem_5	Final Mês*	VE[nov]
CMO (R$/MWh)		624,81	552,40	571,67	460,62	459,35	459,35	404,35
EAR(%EARmax)	55,8	56,3	58,4	65,8	62,3	57,2	57,9	40,8
ENA(%mlt)		63,5	73,5	124,3	56,5	50,2	77,1	82,0

O conteúdo desta publicação foi produzido pelo ONS com base em dados e informações de conhecimento público. É de responsabilidade exclusiva dos agentes e demais interessados a obtenção de outros dados e informações, a realização de análises, estudos e avaliações para fins de tomada de decisões, definição de estratégias de atuação, assunção de compromissos e obrigações e quaisquer outras finalidades, em qualquer tempo e sob qualquer condição. É proibida a reprodução ou utilização total ou parcial do presente sem a identificação da fonte.

Figura 22 – Resumo de outubro/2024 para o Subsistema Nordeste

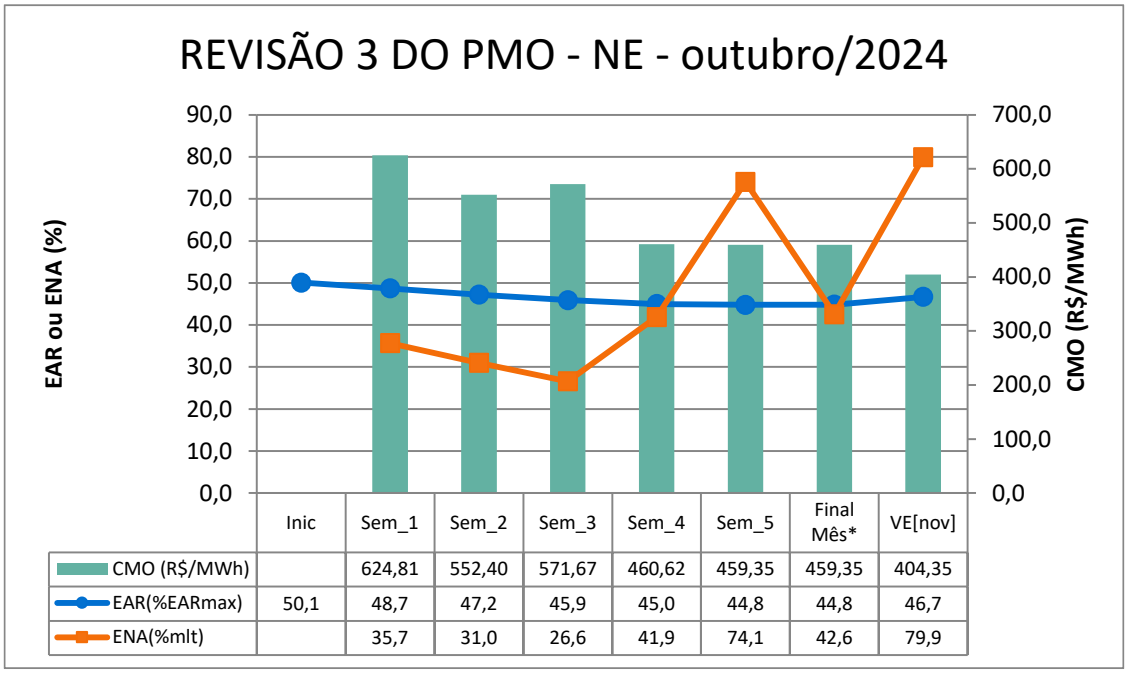

	Inic	Sem_1	Sem_2	Sem_3	Sem_4	Sem_5	Final Mês*	VE[nov]
CMO (R$/MWh)		624,81	552,40	571,67	460,62	459,35	459,35	404,35
EAR(%EARmax)	50,1	48,7	47,2	45,9	45,0	44,8	44,8	46,7
ENA(%mlt)		35,7	31,0	26,6	41,9	74,1	42,6	79,9

Figura 23 – Resumo de outubro/2024 para o Subsistema Norte

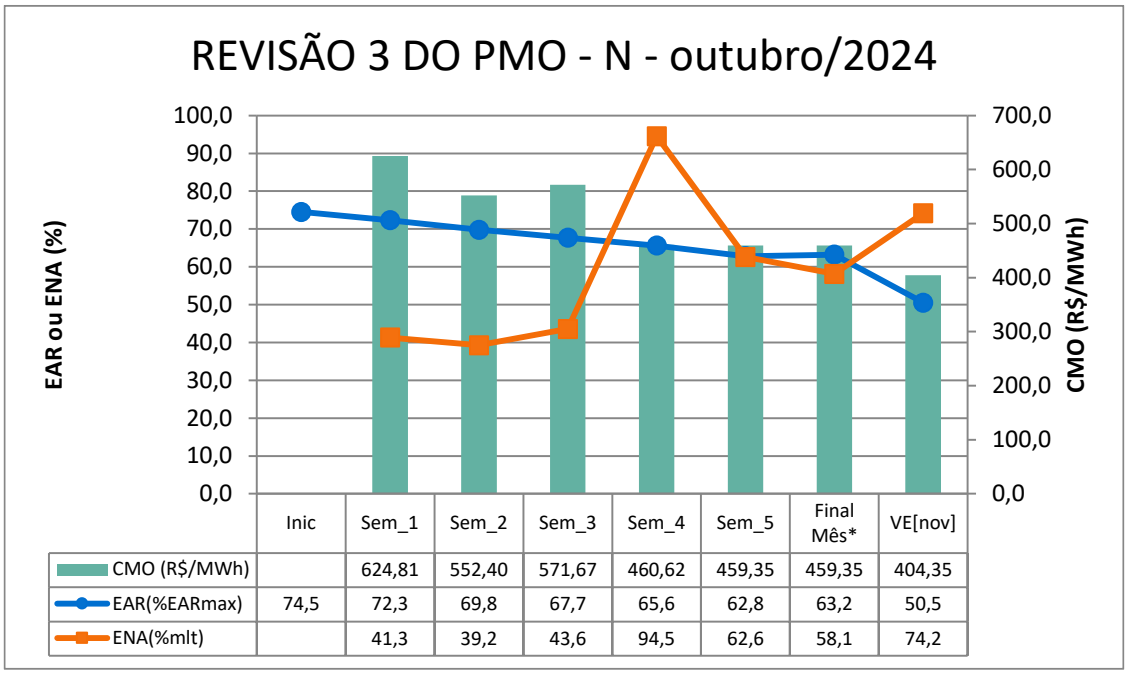

	Inic	Sem_1	Sem_2	Sem_3	Sem_4	Sem_5	Final Mês*	VE[nov]
CMO (R$/MWh)		624,81	552,40	571,67	460,62	459,35	459,35	404,35
EAR(%EARmax)	74,5	72,3	69,8	67,7	65,6	62,8	63,2	50,5
ENA(%mlt)		41,3	39,2	43,6	94,5	62,6	58,1	74,2

O conteúdo desta publicação foi produzido pelo ONS com base em dados e informações de conhecimento público. É de responsabilidade exclusiva dos agentes e demais interessados a obtenção de outros dados e informações, a realização de análises, estudos e avaliações para fins de tomada de decisões, definição de estratégias de atuação, assunção de compromissos e obrigações e quaisquer outras finalidades, em qualquer tempo e sob qualquer condição. É proibida a reprodução ou utilização total ou parcial do presente sem a identificação da fonte.

8. ARMAZENAMENTOS OPERATIVOS

Para uma melhor avaliação de diversos cenários hidrometeorológicos, notadamente, aqueles de curto prazo e suas influências nas previsões de vazões nos subsistemas, os resultados desta Revisão do PMO contemplam cenários de afluências visando melhor representar a ocorrência de precipitação e, consequentemente, seus efeitos sobre as afluências e armazenamentos.

Apresentamos a seguir as correspondentes energias naturais afluentes e os resultados obtidos com a aplicação do cenário de afluência utilizado no estudo.

Tabela 14 – Previsão de ENA do caso de valor esperado das previsões de afluência

Subsistema	ENERGIAS NATURAIS AFLUENTES			
	Previsão Semanal		Previsão Mensal	
	(MWmed)	%MLT	(MWmed)	%MLT
SE/CO	18.940	80	13.762	58
S	7.544	56	10.302	77
NE	1.336	42	1.358	43
N	2.198	92	1.386	58

Tabela 15 – Previsão de %EARmáx para o final do mês

Subsistema	% EARmáx 18/10	% EARmáx - 31/10
	NÍVEL INICIAL	NÍVEL PMO
SE/CO	41,1	40,5
S	65,8	57,9
NE	45,9	44,8
N	67,7	63,2

O conteúdo desta publicação foi produzido pelo ONS com base em dados e informações de conhecimento público. É de responsabilidade exclusiva dos agentes e demais interessados a obtenção de outros dados e informações, a realização de análises, estudos e avaliações para fins de tomada de decisões, definição de estratégias de atuação, assunção de compromissos e obrigações e quaisquer outras finalidades, em qualquer tempo e sob qualquer condição. É proibida a reprodução ou utilização total ou parcial do presente sem a identificação da fonte.

9. RESERVATÓRIOS EQUIVALENTES DE ENERGIA

A seguir são apresentadas as previsões de Energia Natural Afluente para a próxima semana operativa e para o mês de outubro, bem como as previsões de Energia Armazenada nos Reservatórios Equivalentes de Energia – REE, desta revisão do PMO de Outubro de 2024.

Tabela 16 – Previsão de ENA por REE

Valor Esperado das Energias Naturais Afluentes				
REE	Previsão Semanal		Previsão Mensal	
	19/10/2024 a 25/10/2024		out/24	
	(MWmed)	%MLT	(MWmed)	%MLT
Sudeste	3.868	122	2.387	75
Madeira	878	41	912	43
Teles Pires	667	77	583	68
Itaipu	1.807	55	1.770	54
Paraná	10.989	94	7.340	63
Paranapanema	734	29	778	31
Sul	4.124	58	6.670	94
Iguaçu	3.420	55	3.632	58
Nordeste	1.336	42	1.358	43
Norte	2.068	123	1.208	72
Belo Monte	74	17	78	18
Manaus	110	41	129	48

Tabela 17 – Previsão de %EARmáx por REE

% Energia Armazenável Máxima		
REE	Previsão Semanal	Previsão Mensal
	25-out	31-out
	(%EARmáx)	(%EARmáx)
Sudeste	52,9	52,1
Madeira	13,1	11,1
Teles Pires	25,0	26,9
Itaipu	31,6	53,7
Paraná	36,8	36,6
Paranapanema	37,3	37,8
Sul	70,4	65,4
Iguaçu	54,5	50,6
Nordeste	45,0	44,8
Norte	68,6	66,1
Belo Monte	53,0	60,5
Manaus	8,9	7,8

O conteúdo desta publicação foi produzido pelo ONS com base em dados e informações de conhecimento público. É de responsabilidade exclusiva dos agentes e demais interessados a obtenção de outros dados e informações, a realização de análises, estudos e avaliações para fins de tomada de decisões, definição de estratégias de atuação, assunção de compromissos e obrigações e quaisquer outras finalidades, em qualquer tempo e sob qualquer condição. É proibida a reprodução ou utilização total ou parcial do presente sem a identificação da fonte.

10. DESPACHO TÉRMICO POR MODALIDADE, PATAMAR DE CARGA E USINA

Nas tabelas abaixo, a diferenciação entre geração por inflexibilidade e por ordem de mérito tem caráter informativo, com o objetivo de detalhar a informação de inflexibilidade enviada pelos respectivos agentes para esta revisão do PMO. Ressalta-se que nas etapas de Programação Diária e Tempo Real, o montante despachado nas usinas termelétricas indicadas por ordem de mérito é plenamente intitulado como ordem de mérito.

Tabela 18 – Geração Termelétrica indicada pelo DECOMP para o subsistema Sudeste/Centro-Oeste

REGIÃO SUDESTE/CENTRO-OESTE																	
Térmicas Potência (MW)	Combustível	CVU	Inflexibilidade			Ordem de Mérito			Total Mérito e INFL.			Razão Elétrica			Total UTE		
			P	M	L	P	M	L	P	M	L	P	M	L	P	M	L
ATLAN_CSA (255)	Resíduos	0,00	123,3	123,3	123,3				123,3	123,3	123,3				123,3	123,3	123,3
CUIABA CC (529)	Gás	---															
DAIA (44)	Diesel	---															
TNORTE 2 (349)	Óleo	---															
W.ARJONA (177)	Gás	---															
W.ARJONA O (177)	Diesel	---															
XAVANTES (54)	Diesel	---															
ANGRA 2 (1350)	Nuclear	20,12	1350,0	1350,0	1350,0	0,0	0,0	0,0	1350,0	1350,0	1350,0				1350,0	1350,0	1350,0
ANGRA 1 (640)	Nuclear	31,17	640,0	640,0	640,0	0,0	0,0	0,0	640,0	640,0	640,0				640,0	640,0	640,0
NORTEFLU 1 (400)	Gás	113,31				400,0	400,0	400,0	400,0	400,0	400,0				400,0	400,0	400,0
NORTEFLU 2 (100)	Gás	128,73				72,0	72,0	72,0	72,0	72,0	72,0				72,0	72,0	72,0
O.PINTADA (50)	Biomassa	138,91	30,0	30,0	30,0	20,0	20,0	20,0	50,0	50,0	50,0				50,0	50,0	50,0
UTE STA VI (41)	Biomassa	150,06	18,0	18,0	18,0	23,0	23,0	23,0	41,0	41,0	41,0				41,0	41,0	41,0
M.AZUL (566)	Gás	154,46				565,5	565,5	565,5	565,5	565,5	565,5				565,5	565,5	565,5
BAIXADA FL (530)	Gás	181,34				530,0	530,0	530,0	530,0	530,0	530,0				530,0	530,0	530,0
SANTA CRUZ (500)	GNL	184,58															
NORTEFLU 3 (200)	Gás	247,40				0,0	0,0	0,0									
ATLANTICO (235)	Resíduos	249,65	218,7	218,7	218,7	0,0	0,0	0,0	218,7	218,7	218,7				218,7	218,7	218,7
LUIZORMELO (204)	GNL	276,35				0,0	0,0	0,0									
ST.CRUZ 34 (436)	Óleo	310,41															
UTE GNA I (1338)	Gás	349,07				1338,0	1338,0	1338,0	1338,0	1338,0	1338,0				1338,0	1338,0	1338,0
TERMORIO (989)	Gás	407,34	270,0	270,0	270,0	719,2	719,2	719,2	989,2	989,2	989,2				989,2	989,2	989,2
CUBATAO (216)	Gás	433,22	110,0	110,0	110,0	99,0	99,0	99,0	209,0	209,0	209,0				209,0	209,0	209,0
PIRAT.12 O (200)	Gás	470,34				0,0											
NORTEFLU 4 (127)	Gás	731,63															
IBIRITE (235)	Gás	873,91															
T.MACAE (929)	Gás	931,56															
KARKEY 013 (259)	Gás	934,84	30,0	30,0	30,0				30,0	30,0	30,0				30,0	30,0	30,0
KARKEY 019 (116)	Gás	934,84															
T.LAGOAS (350)	Gás	1042,40															
VIANA (175)	Óleo	1042,47															
PORSUD II (78)	Gás	1088,86															
PORSUD I (116)	Gás	1090,54															
J.FORA (87)	Gás	1264,49															
SEROPEDICA (360)	Gás	1280,71															
PAULINIA (16)	Gás	1337,10	15,7	15,7	15,7				15,7	15,7	15,7				15,7	15,7	15,7
LORM_PCS (36)	Gás	1367,18															
POVOACAO I (75)	Gás	1367,18															
VIANA I (37)	Gás	1367,18															
NPIRATINGA (572)	Gás	1523,17															
PALMEIR_GO (176)	Diesel	1731,15															
TOTAL SE/CO (13147)			2805,7	2805,7	2805,7	3766,7	3766,7	3766,7	6572,4	6572,4	6572,4	0,0	0,0	0,0	6572,4	6572,4	6572,4

Tabela 19 – Geração Termelétrica indicada pelo DECOMP para o subsistema Sul

REGIÃO SUL																	
Térmicas Potência (MW)	Combustível	CVU	Inflexibilidade			Ordem de Mérito			Total Mérito e INFL.			Razão Elétrica			Total UTE		
			P	M	L	P	M	L	P	M	L	P	M	L	P	M	L
ARAUCARIA (484)	Gás	---															
URUGUAIANA (640)	Gás	---															
PAMPA SUL (345)	Carvão	96,61	285,0	285,0	285,0	60,0	60,0	60,0	345,0	345,0	345,0				345,0	345,0	345,0
SAO SEPE (8)	Biomassa	108,38	4,0	4,0	4,0	0,0	0,0	0,0	4,0	4,0	4,0				4,0	4,0	4,0
CANDIOTA_3 (350)	Carvão	112,25	320,0	320,0	320,0	0,0	0,0	0,0	320,0	320,0	320,0				320,0	320,0	320,0
J.LACER. C (330)	Carvão	325,27	264,0	220,0	120,0	0,0	0,0	0,0	264,0	220,0	120,0				264,0	220,0	120,0
FIGUEIRA (20)	Carvão	330,64				0,0	0,0	0,0									
J.LACER. B (220)	Carvão	378,90	110,0	110,0	110,0	110,0	110,0	110,0	220,0	220,0	220,0				220,0	220,0	220,0
J.LAC. A2 (110)	Carvão	387,75	50,0	50,0	50,0	60,0	60,0	60,0	110,0	110,0	110,0				110,0	110,0	110,0
J.LAC. A1 (80)	Carvão	453,14				80,0	80,0		80,0	80,0					80,0	80,0	0,0
B.BONITA I (10)	Gás	742,99	3,7	3,7	3,7				3,7	3,7	3,7				3,7	3,7	3,7
CANOAS (249)	Gás	1351,42															
TOTAL SUL (2846)			1036,7	992,7	892,7	310,0	310,0	230,0	1346,7	1302,7	1122,7	0,0	0,0	0,0	1346,7	1302,7	1122,7

O conteúdo desta publicação foi produzido pelo ONS com base em dados e informações de conhecimento público. É de responsabilidade exclusiva dos agentes e demais interessados a obtenção de outros dados e informações, a realização de análises, estudos e avaliações para fins de tomada de decisões, definição de estratégias de atuação, assunção de compromissos e obrigações e quaisquer outras finalidades, em qualquer tempo e sob qualquer condição. É proibida a reprodução ou utilização total ou parcial do presente sem a identificação da fonte.

Tabela 20 – Geração Termelétrica indicada pelo DECOMP para o subsistema Nordeste

REGIÃO NORDESTE																	
Térmicas Potência (MW)	Combustível	CVU	Inflexibilidade			Ordem de Mérito			Total Mérito e INFL.			Razão Elétrica			Total UTE		
			P	M	L	P	M	L	P	M	L	P	M	L	P	M	L
PETROLINA (136)	Óleo	---															
POTIGUAR (53)	Diesel	---															
POTIGUAR_3 (66)	Diesel	---															
TERMOCEARA (223)	Gás	---															
ERB CANDEI (17)	Biomassa	108,45	3,5	3,5	3,5	5,0	5,0	5,0	8,5	8,5	8,5				8,5	8,5	8,5
PROSP_I (28)	Gás	204,55				9,0	9,0	9,0	9,0	9,0	9,0				9,0	9,0	9,0
PROSP_III (56)	Gás	208,41	1,0	1,0	1,0	55,0	55,0	55,0	56,0	56,0	56,0				56,0	56,0	56,0
PROSP_II (37)	Gás	346,33				37,3	37,3	37,3	37,3	37,3	37,3				37,3	37,3	37,3
PSERGIPE I (1593)	GNL	348,03															
P.PECEM1 (720)	Carvão	362,52				720,0	720,0	720,0	720,0	720,0	720,0				720,0	720,0	720,0
P.PECEM2 (365)	Carvão	367,97				365,0	365,0	365,0	365,0	365,0	365,0				365,0	365,0	365,0
VALE ACU (368)	Gás	450,86				110,0	110,0	110,0	110,0	110,0	110,0				110,0	110,0	110,0
PERNAMBU_3 (201)	Óleo	895,99															
TERMOPE (550)	Gás	963,38															
MARACANAU (168)	Óleo	1012,25															
T.BAHIA (186)	Gás	1014,29															
TERMOCABO (50)	Óleo	1029,75															
TERMONE (171)	Óleo	1034,78															
TERMOPB (171)	Óleo	1034,78															
CAMPINA_GR (169)	Óleo	1042,49															
SUAPE II (381)	Óleo	1061,68															
GLOBAL I (149)	Óleo	1181,58															
GLOBAL II (149)	Óleo	1181,58															
C.MURICY 2 (144)	Óleo	2394,86															
PECEM 2 (144)	Óleo	2419,86															
TOTAL NE (6007)			4,5	4,5	4,5	1301,3	1301,3	1301,3	1305,8	1305,8	1305,8	0,0	0,0	0,0	1305,8	1305,8	1305,8

Tabela 21 – Geração Termelétrica indicada pelo DECOMP para o subsistema Norte

REGIÃO NORTE																	
Térmicas Potência (MW)	Combustível	CVU	Inflexibilidade			Ordem de Mérito			Total Mérito e INFL.			Razão Elétrica			Total UTE		
			P	M	L	P	M	L	P	M	L	P	M	L	P	M	L
C. ROCHA (85)	Gás	0,00	65,0	65,0	65,0				65,0	65,0	65,0				65,0	65,0	65,0
JARAQUI (75)	Gás	0,00	63,0	63,0	63,0				63,0	63,0	63,0				63,0	63,0	63,0
MANAUARA (73)	Gás	0,00	64,6	64,3	63,8				64,6	64,3	63,8				64,6	64,3	63,8
PONTA NEGR (73)	Gás	0,00	64,0	64,0	64,0				64,0	64,0	64,0				64,0	64,0	64,0
TAMBAQUI (93)	Gás	0,00	63,0	63,0	63,0				63,0	63,0	63,0				63,0	63,0	63,0
APARECIDA (166)	Gás	95,36	75,0	75,0	75,0	32,1	25,2	14,5	107,1	100,2	89,5				107,1	100,2	89,5
UTE MAUA 3 (591)	Gás	95,36	264,0	264,0	264,0	199,8	199,8	199,8	463,8	463,8	463,8				463,8	463,8	463,8
MARANHAO3 (519)	Gás	105,87	490,0	490,0	490,0	7,2	14,4	23,0	497,2	504,4	513,0				497,2	504,4	513,0
MARANHAO V (338)	Gás	171,74				328,1	331,3	335,0	328,1	331,3	335,0				328,1	331,3	335,0
MARANHAOIV (338)	Gás	171,74				328,1	331,3	335,0	328,1	331,3	335,0				328,1	331,3	335,0
PARNAIBA_V (386)	Vapor	222,58			3,0	353,8	357,6	359,2	353,8	357,6	362,2				353,8	357,6	362,2
N.VENECIA2 (270)	Gás	286,88				172,0	174,1	176,5	172,0	174,1	176,5				172,0	174,1	176,5
P. ITAQUI (360)	Carvão	360,18				360,1	360,1	360,1	360,1	360,1	360,1				360,1	360,1	360,1
PARNAIB_IV (56)	Gás	498,71															
GERAMAR1 (166)	Óleo	1042,45															
GERAMAR2 (166)	Óleo	1042,45															
TOTAL NORTE (4045)			1148,6	1148,3	1150,8	1781,2	1793,8	1803,1	2929,8	2942,1	2953,9	0,0	0,0	0,0	2929,8	2942,1	2953,9

O conteúdo desta publicação foi produzido pelo ONS com base em dados e informações de conhecimento público. É de responsabilidade exclusiva dos agentes e demais interessados a obtenção de outros dados e informações, a realização de análises, estudos e avaliações para fins de tomada de decisões, definição de estratégias de atuação, assunção de compromissos e obrigações e quaisquer outras finalidades, em qualquer tempo e sob qualquer condição. É proibida a reprodução ou utilização total ou parcial do presente sem a identificação da fonte.