1. APRESENTAÇÃO

Na semana de 17/08 a 23/08/2024 ocorreu precipitação nas bacias dos rios Jacuí, Taquari-Antas e Uruguai.

Na semana de 24/08 a 30/08/2024 deve ocorrer precipitação nas bacias dos rios Jacuí, Taquari-Antas, Uruguai, Paranapanema, Tietê e em pontos isolados do Paraíba do Sul.

Os valores médios semanais do Custo Marginal de Operação – CMO dos subsistemas do SIN sofreram as seguintes alterações em relação à semana anterior:

- SE/CO: de R$ 98,26/MWh para R$ 94,25/MWh
- Sul: de R$ 98,26/MWh para R$ 94,25/MWh
- Nordeste: de R$ 98,26/MWh para R$ 94,25/MWh
- Norte: de R$ 98,26/MWh para R$ 94,25/MWh

Desde o dia 01/01/2020, o despacho por ordem de mérito é indicado diariamente pelos resultados do modelo DESSEM. Assim, o despacho por ordem de mérito semanal, conforme publicado nesse documento, tem caráter apenas informativo. Da mesma forma, desde o dia 01/01/2021, a formação de preço deixou o formato semanal/patamar de carga e passou a ser horário, de acordo também com os resultados do modelo DESSEM.

2. NOTÍCIAS

Nos dias 29 e 30 de agosto será realizada a reunião de elaboração do PMO de Setembro de 2024, com transmissão ao vivo através do site do ONS.

3. INFORMAÇÕES CONJUNTURAIS PARA ELABORAÇÃO DO PMO

3.1. Informações Hidrometeorológicas

3.1.1. Condições antecedentes

A atuação de uma frente fria na Região Sul no final da semana operativa ocasionou precipitação nas bacias dos rios Jacuí, Taquari-Antas e Uruguai (Figura 1).

O conteúdo desta publicação foi produzido pelo ONS com base em dados e informações de conhecimento público. É de responsabilidade exclusiva dos agentes e demais interessados a obtenção de outros dados e informações, a realização de análises, estudos e avaliações para fins de tomada de decisões, definição de estratégias de atuação, assunção de compromissos e obrigações e quaisquer outras finalidades, em qualquer tempo e sob qualquer condição. É proibida a reprodução ou utilização total ou parcial do presente sem a identificação da fonte.

Figura 1 - Precipitação observada por satélite (mm) no período de 17 a 22/08/2024

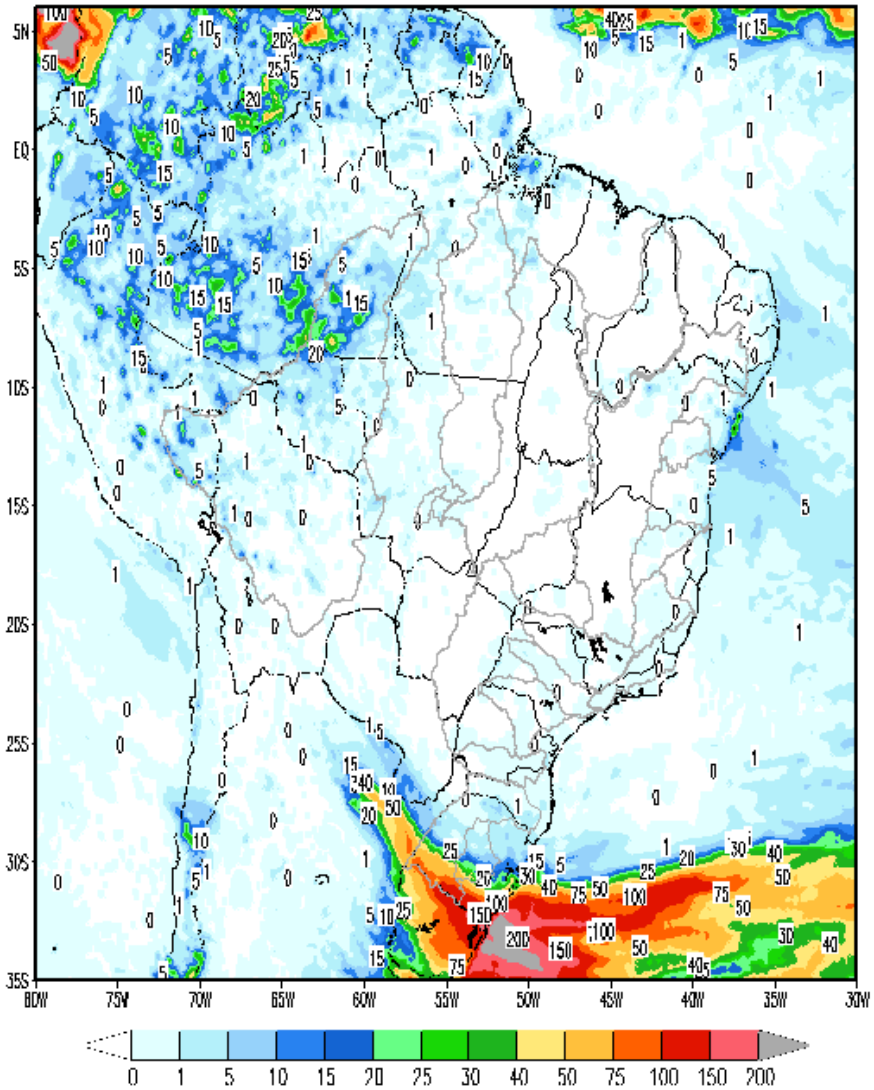

A Tabela 1 apresenta as energias naturais afluentes das semanas recentes. São apresentados os valores verificados na semana 10/08/2024 a 16/08/2024 e os estimados para fechamento da semana de 17/08/2024 a 23/08/2024.

Tabela 1 – Tendência hidrológica da ENA da Revisão 4 de Agosto/2024

Revisão 4 do PMO de agosto/2024 - ENAs				
Subsistema	10/08 a 16/08/2024		17/08 a 23/08/2024	
	MWmed	%MLT	MWmed	%MLT
SE/CO	12.623	62	12.056	59
S	5.792	58	4.262	43
NE	1.408	43	1.386	42
N	1.661	52	1.499	47

O conteúdo desta publicação foi produzido pelo ONS com base em dados e informações de conhecimento público. É de responsabilidade exclusiva dos agentes e demais interessados a obtenção de outros dados e informações, a realização de análises, estudos e avaliações para fins de tomada de decisões, definição de estratégias de atuação, assunção de compromissos e obrigações e quaisquer outras finalidades, em qualquer tempo e sob qualquer condição. É proibida a reprodução ou utilização total ou parcial do presente sem a identificação da fonte.

3.1.2. Previsões - Próxima semana

O avanço de uma frente fria e a atuação de áreas de instabilidade no início da semana na Região Sul e Sudeste ocasiona precipitação nas bacias dos rios Jacuí, Taquari-Antas, Uruguai, Paranapanema, Tietê e em pontos isolados do Paraíba do Sul (Figura 2).

Figura 2 - Precipitação acumulada prevista pelo modelo ECMWF – 24 a 30/08/2024

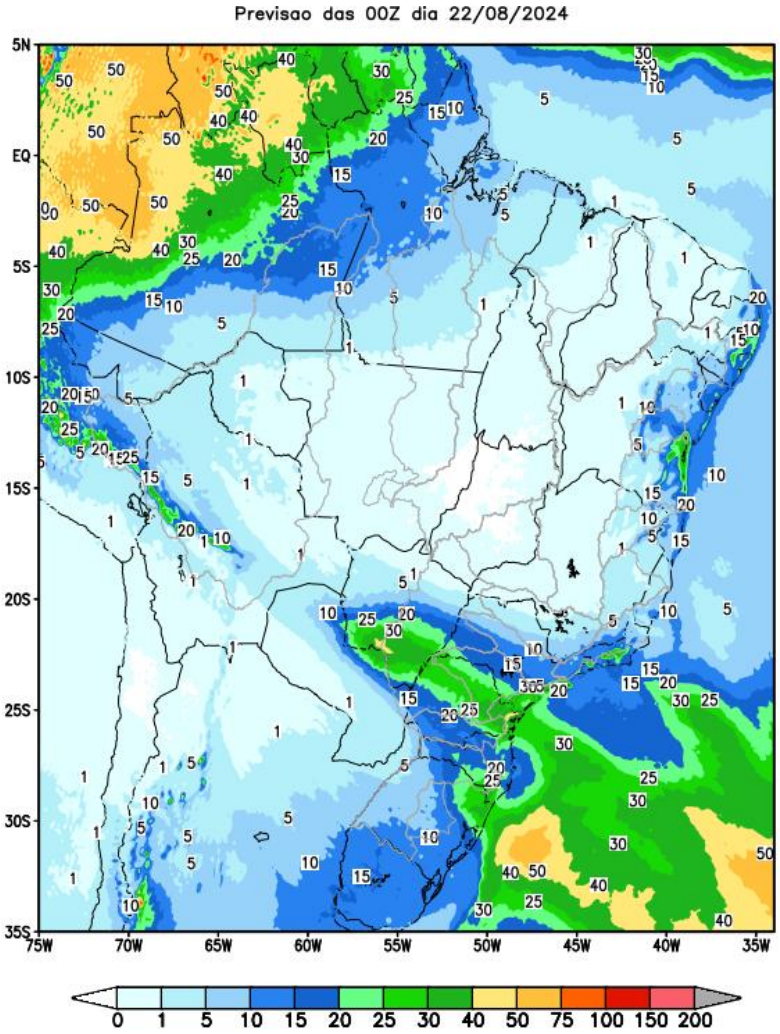

Em comparação com os valores estimados para a semana em curso, prevê-se para a próxima semana operativa ascensão nas afluências do subsistema Sul e recessão nas afluências dos subsistemas Sudeste/Centro-Oeste, Nordeste e Norte. A previsão mensal para agosto indica a ocorrência de afluências abaixo da média histórica para todos os subsistemas.

Tabela 2 – Previsão de ENAs da Revisão 4 de Agosto/2024

Revisão 4 do PMO de agosto/2024 - ENAs previstas				
Subsistema	24/08 a 30/08/2024		Mês de agosto	
	MWmed	%MLT	MWmed	%MLT
SE/CO	10.924	53	11.990	58
S	5.209	52	6.187	62
NE	1.333	41	1.405	43
N	1.352	42	1.585	50

O conteúdo desta publicação foi produzido pelo ONS com base em dados e informações de conhecimento público. É de responsabilidade exclusiva dos agentes e demais interessados a obtenção de outros dados e informações, a realização de análises, estudos e avaliações para fins de tomada de decisões, definição de estratégias de atuação, assunção de compromissos e obrigações e quaisquer outras finalidades, em qualquer tempo e sob qualquer condição. É proibida a reprodução ou utilização total ou parcial do presente sem a identificação da fonte.

As figuras a seguir ilustram as ENAs semanais verificadas e previstas para as Revisões 3 e 4 do PMO de agosto/2024.

Figura 3 - Energias Naturais Afluentes ao Subsistema Sudeste/Centro-Oeste das Revisões 3 e 4 do PMO de Agosto/2024

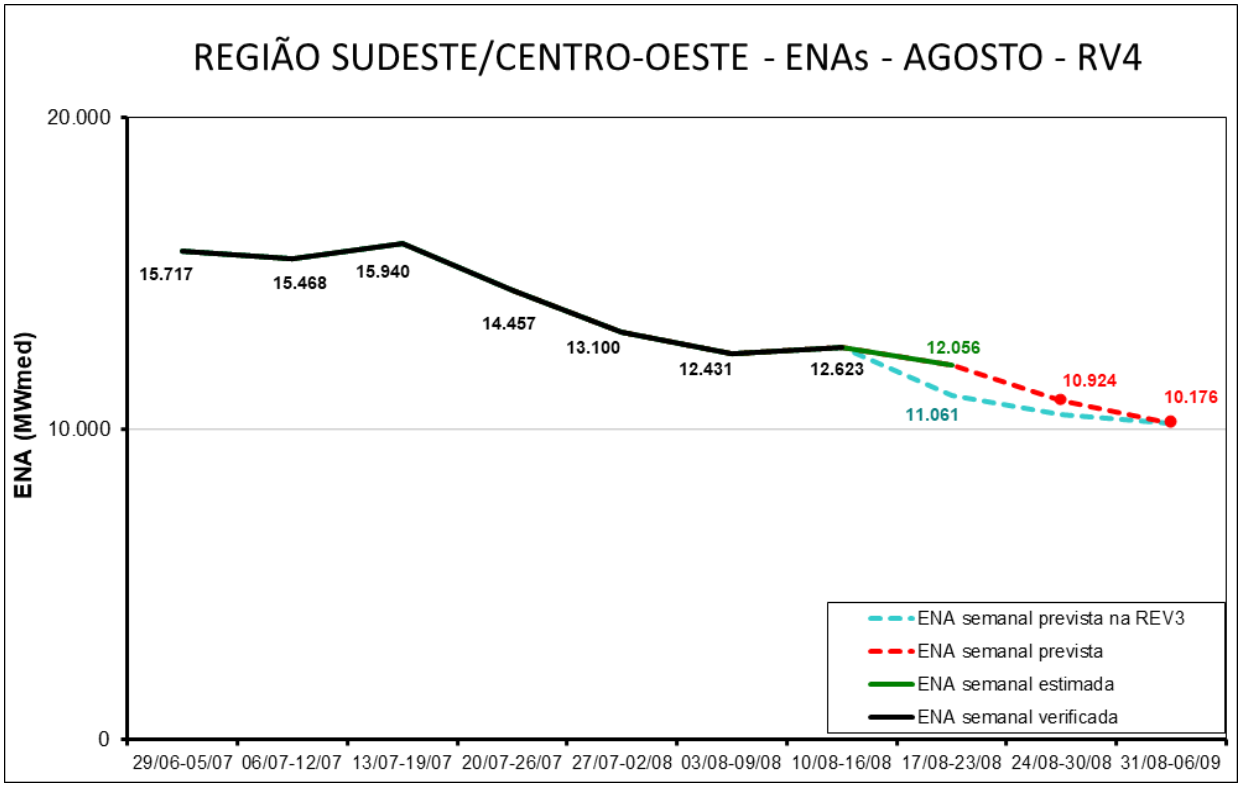

Figura 4 - Energias Naturais Afluentes ao Subsistema Sul das Revisões 3 e 4 do PMO de Agosto/2024

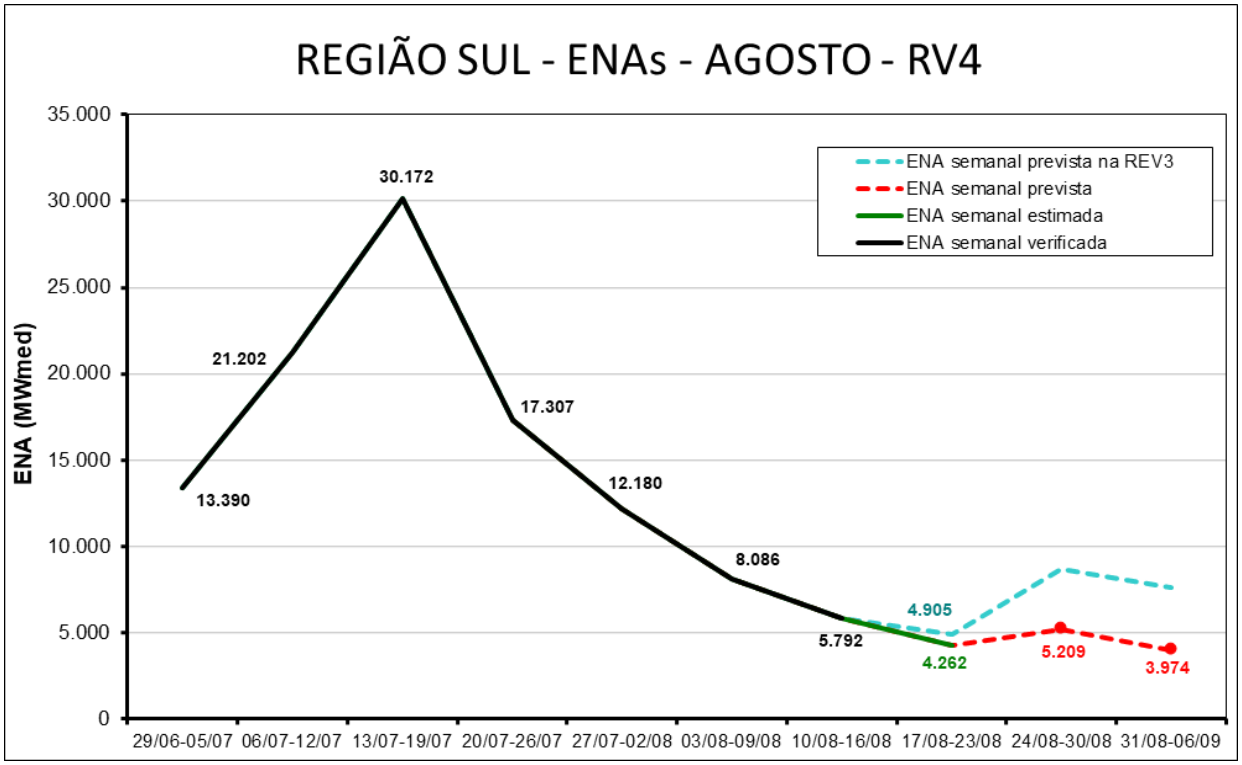

O conteúdo desta publicação foi produzido pelo ONS com base em dados e informações de conhecimento público. É de responsabilidade exclusiva dos agentes e demais interessados a obtenção de outros dados e informações, a realização de análises, estudos e avaliações para fins de tomada de decisões, definição de estratégias de atuação, assunção de compromissos e obrigações e quaisquer outras finalidades, em qualquer tempo e sob qualquer condição. É proibida a reprodução ou utilização total ou parcial do presente sem a identificação da fonte.

Figura 5 - Energias Naturais Afluentes ao Subsistema Nordeste das Revisões 3 e 4 do PMO de Agosto/2024

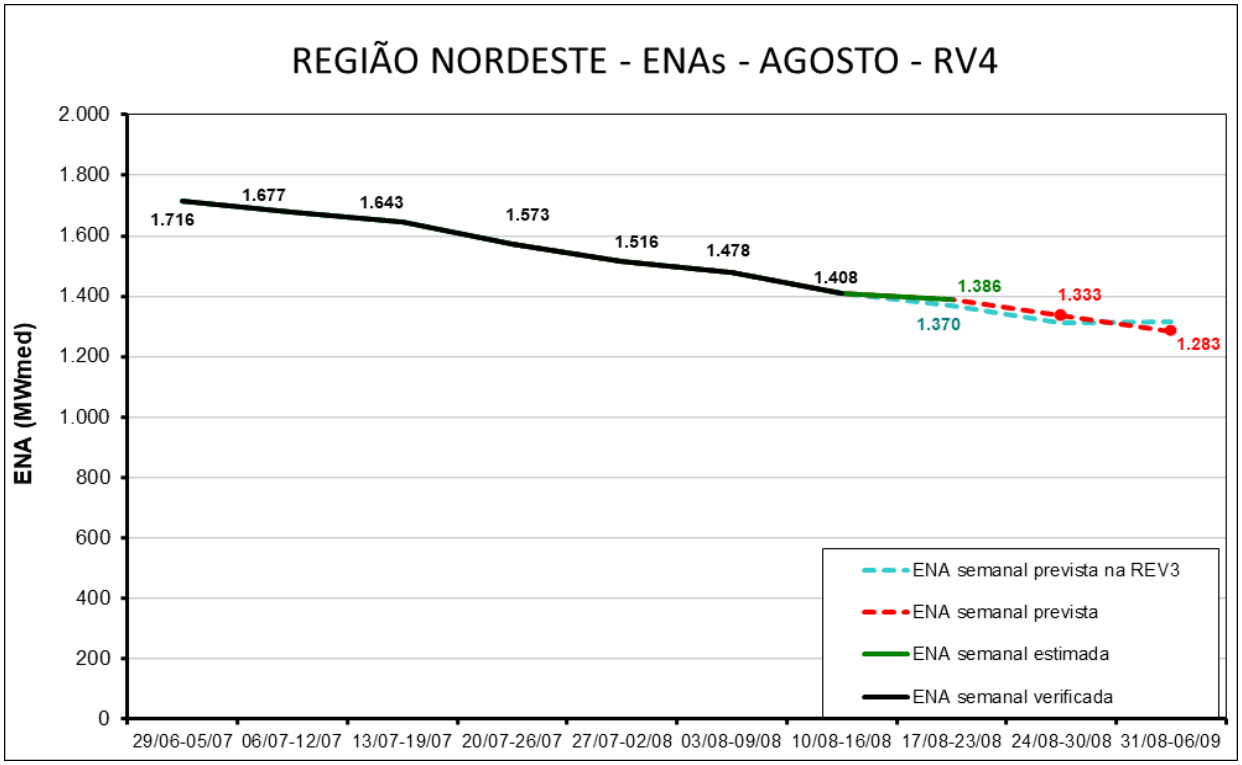

Figura 6 - Energias Naturais Afluentes ao Subsistema Norte das Revisões 3 e 4 do PMO de Agosto/2024

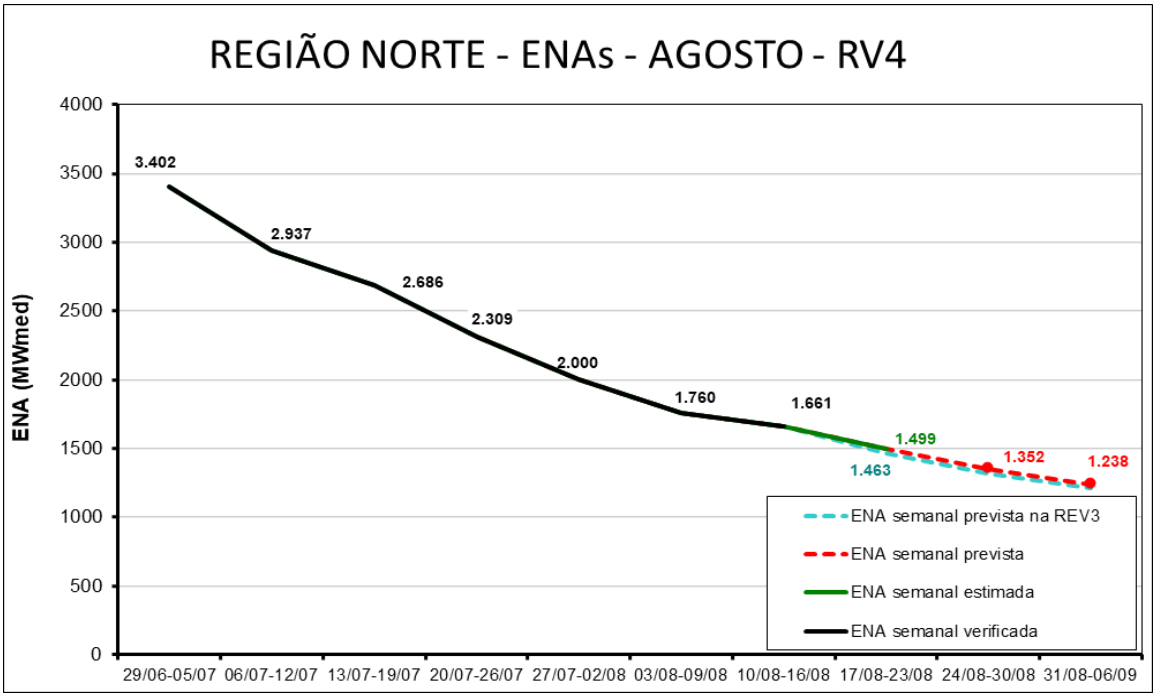

O conteúdo desta publicação foi produzido pelo ONS com base em dados e informações de conhecimento público. É de responsabilidade exclusiva dos agentes e demais interessados a obtenção de outros dados e informações, a realização de análises, estudos e avaliações para fins de tomada de decisões, definição de estratégias de atuação, assunção de compromissos e obrigações e quaisquer outras finalidades, em qualquer tempo e sob qualquer condição. É proibida a reprodução ou utilização total ou parcial do presente sem a identificação da fonte.

3.1.3. Cenários de ENAs para a Revisão 4 de Agosto/2024

As figuras a seguir apresentam as características dos cenários de energias naturais afluentes gerados na Revisão 4 de Agosto/2024, para acoplamento com a FCF do mês de Setembro/2024. São mostradas, para os quatro subsistemas, as amplitudes e as Funções de Distribuição Acumulada dos cenários de ENA, comparativamente com os valores considerados para as revisões anteriores do PMO de Agosto/2024.

Figura 7 - Amplitude dos Cenários de ENA para o Subsistema Sudeste/Centro-Oeste, em %MLT, para a Revisão 4 de Agosto/2024

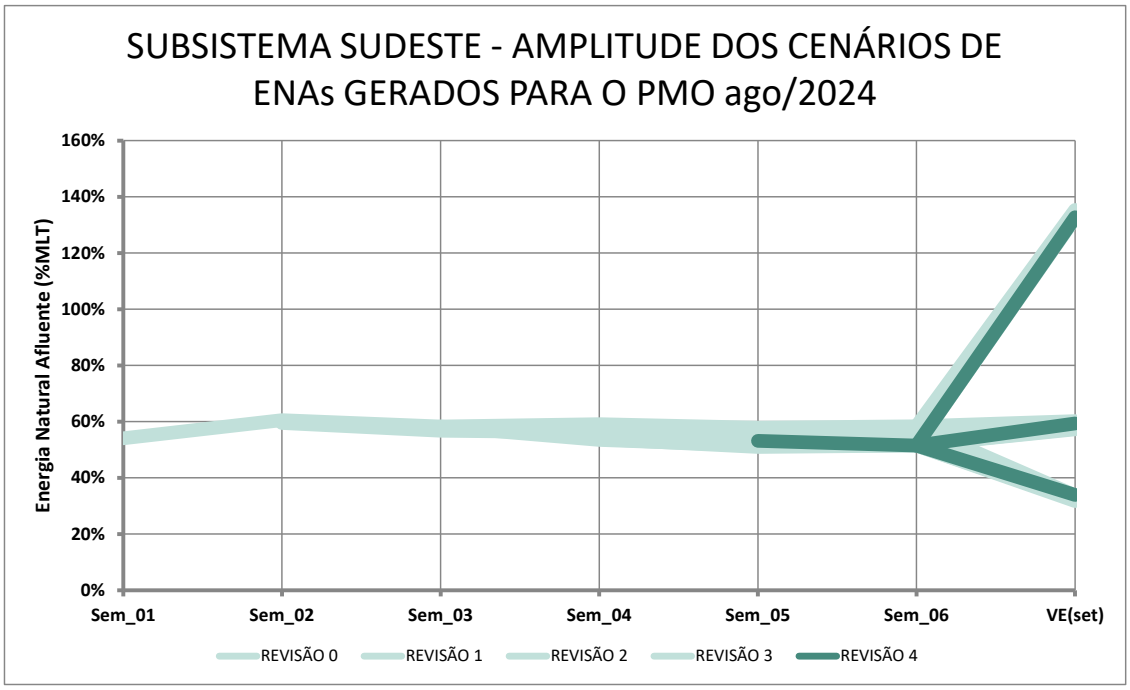

Figura 8 - Função de Distribuição Acumulada dos Cenários para o Subsistema Sudeste/Centro-Oeste para a Revisão 4 de Agosto/2024

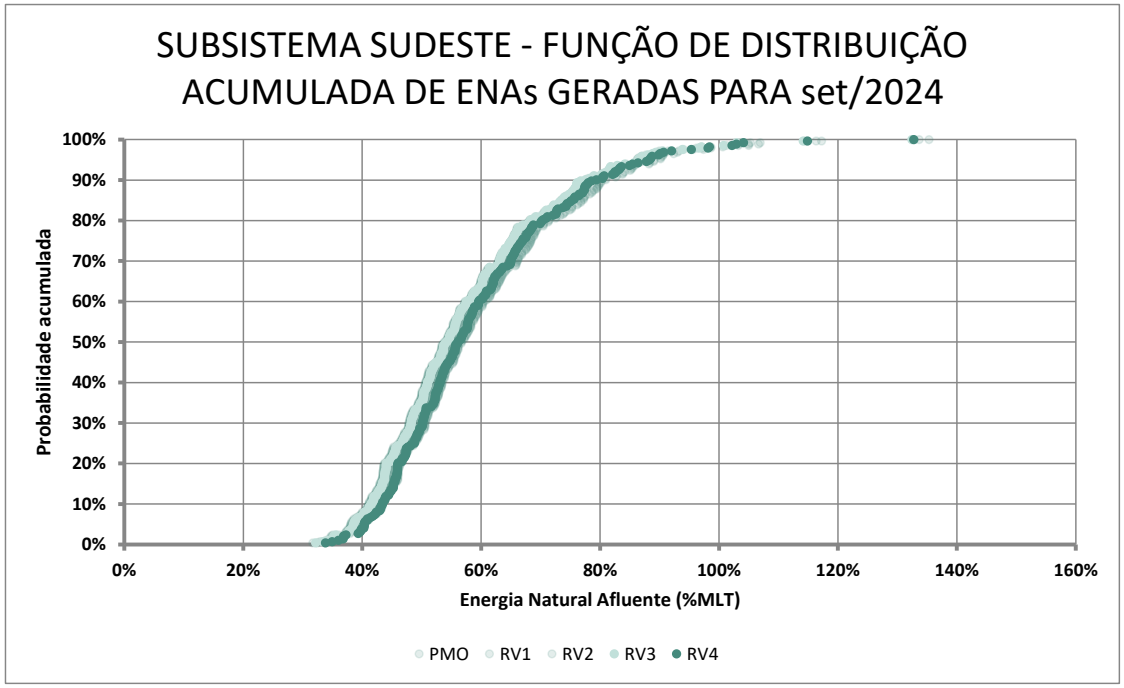

O conteúdo desta publicação foi produzido pelo ONS com base em dados e informações de conhecimento público. É de responsabilidade exclusiva dos agentes e demais interessados a obtenção de outros dados e informações, a realização de análises, estudos e avaliações para fins de tomada de decisões, definição de estratégias de atuação, assunção de compromissos e obrigações e quaisquer outras finalidades, em qualquer tempo e sob qualquer condição. É proibida a reprodução ou utilização total ou parcial do presente sem a identificação da fonte.

Figura 9 - Amplitude dos Cenários de ENA para o Subsistema Sul, em %MLT, para a Revisão 4 de Agosto/2024

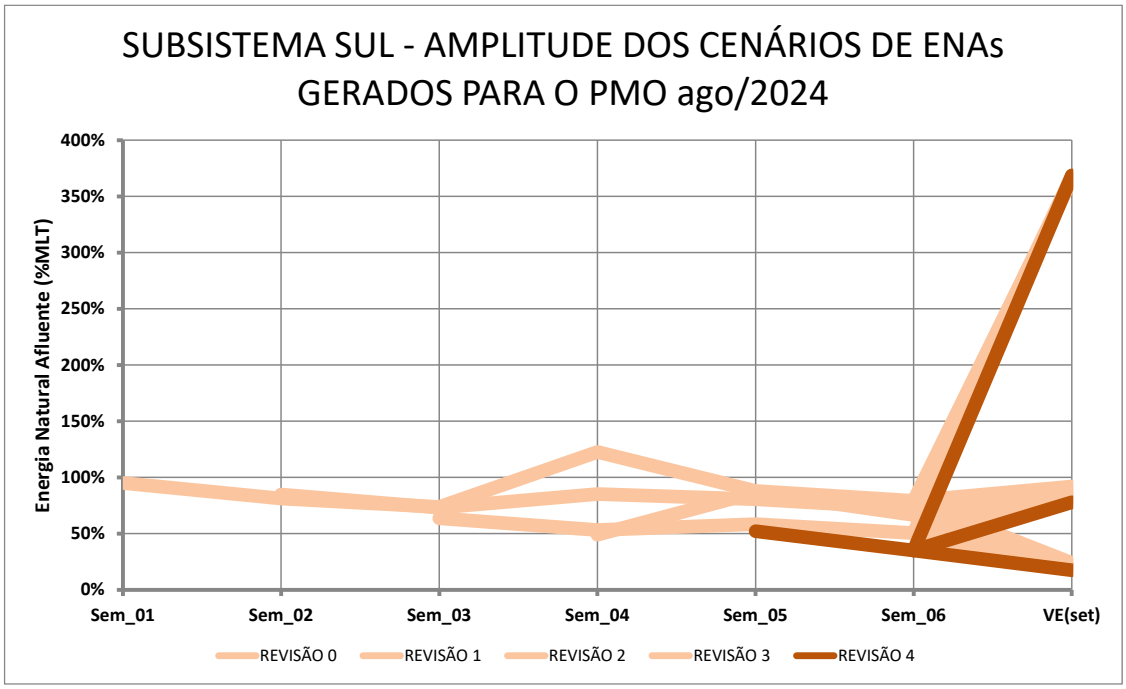

Figura 10 - Função de Distribuição Acumulada dos Cenários para o Subsistema Sul para a Revisão 4 de Agosto/2024

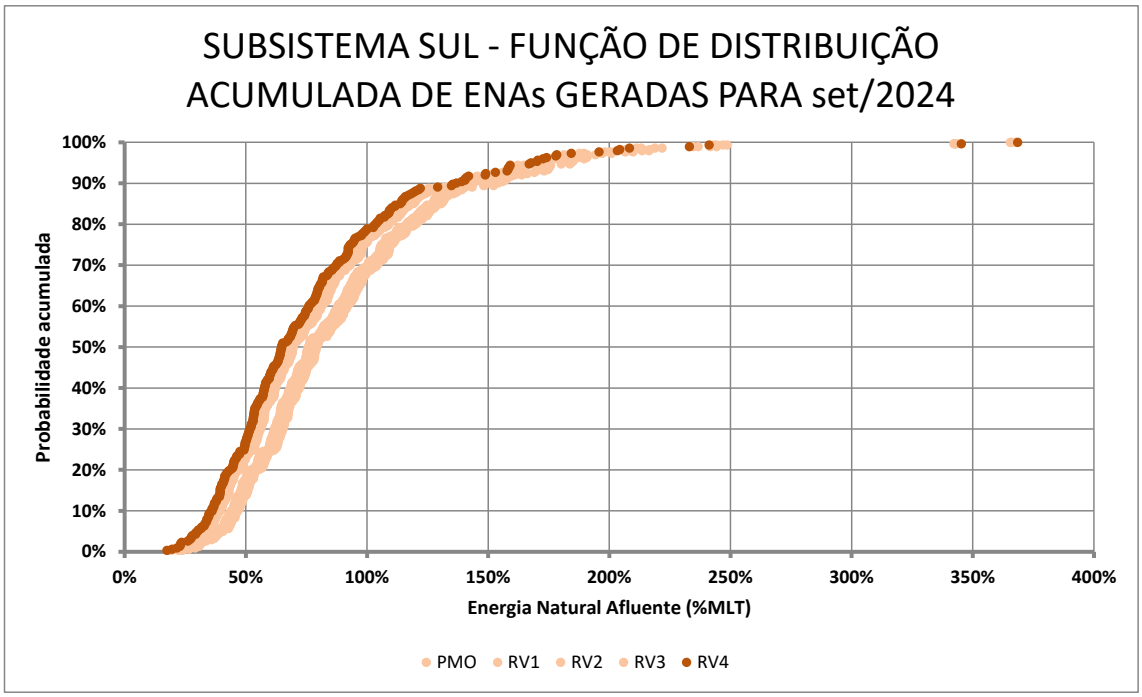

O conteúdo desta publicação foi produzido pelo ONS com base em dados e informações de conhecimento público. É de responsabilidade exclusiva dos agentes e demais interessados a obtenção de outros dados e informações, a realização de análises, estudos e avaliações para fins de tomada de decisões, definição de estratégias de atuação, assunção de compromissos e obrigações e quaisquer outras finalidades, em qualquer tempo e sob qualquer condição. É proibida a reprodução ou utilização total ou parcial do presente sem a identificação da fonte.

Figura 11 - Amplitude dos Cenários de ENA para o Subsistema Nordeste em %MLT, para a Revisão 4 de Agosto/2024

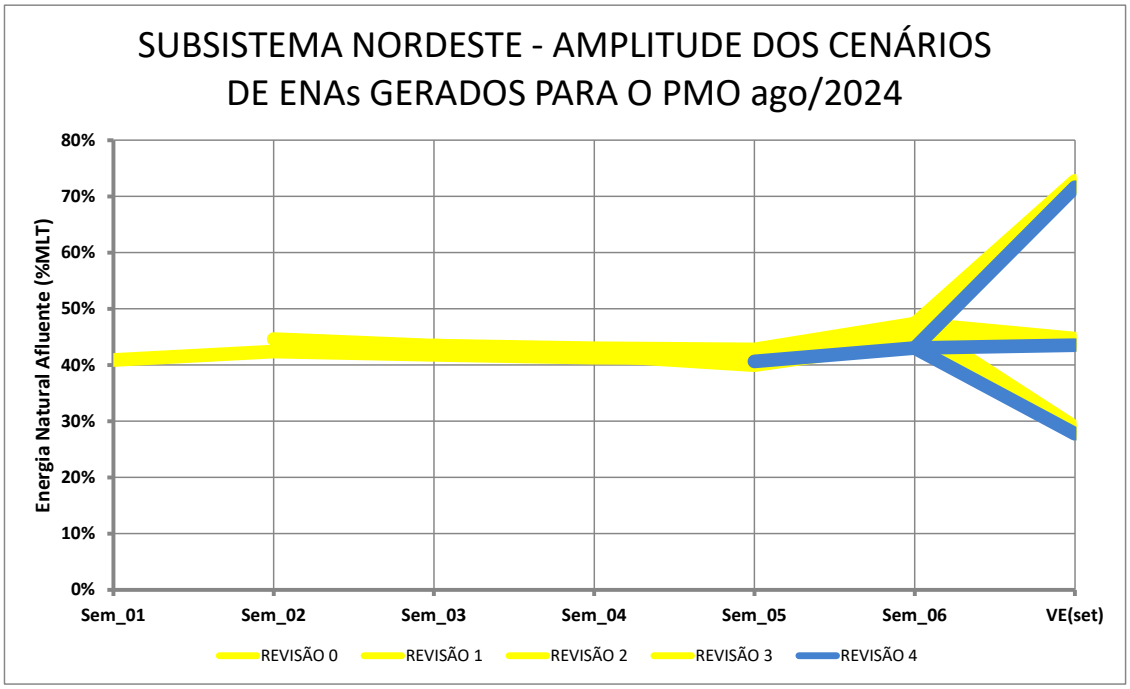

Figura 12 - Função de Distribuição Acumulada dos Cenários para o Subsistema Nordeste para a Revisão 4 de Agosto/2024

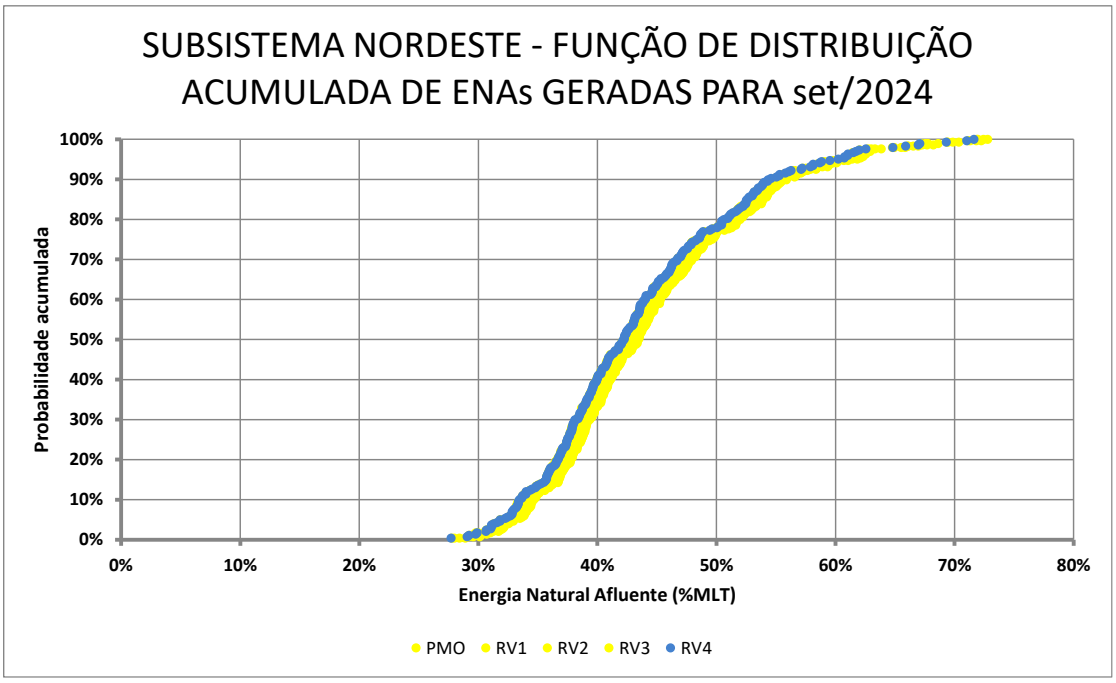

O conteúdo desta publicação foi produzido pelo ONS com base em dados e informações de conhecimento público. É de responsabilidade exclusiva dos agentes e demais interessados a obtenção de outros dados e informações, a realização de análises, estudos e avaliações para fins de tomada de decisões, definição de estratégias de atuação, assunção de compromissos e obrigações e quaisquer outras finalidades, em qualquer tempo e sob qualquer condição. É proibida a reprodução ou utilização total ou parcial do presente sem a identificação da fonte.

Figura 13 - Amplitude dos Cenários de ENA para o Subsistema Norte, em %MLT, para a Revisão 4 de Agosto/2024

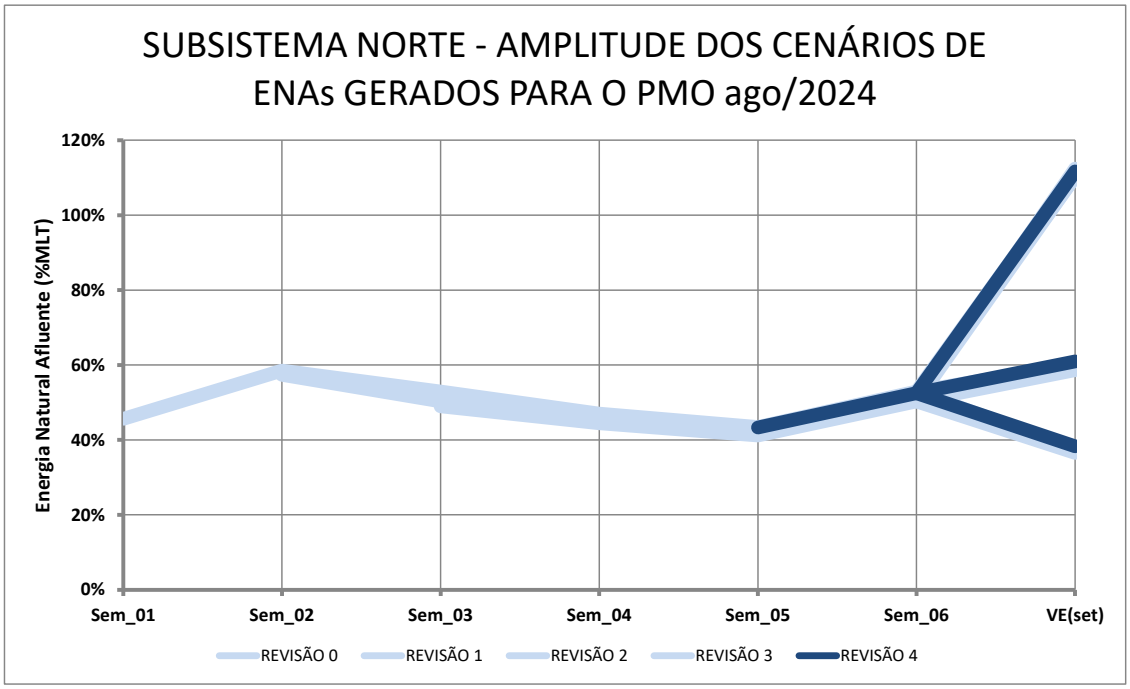

Figura 14 - Função de Distribuição Acumulada dos Cenários para o Subsistema Norte para a Revisão 4 de Agosto/2024

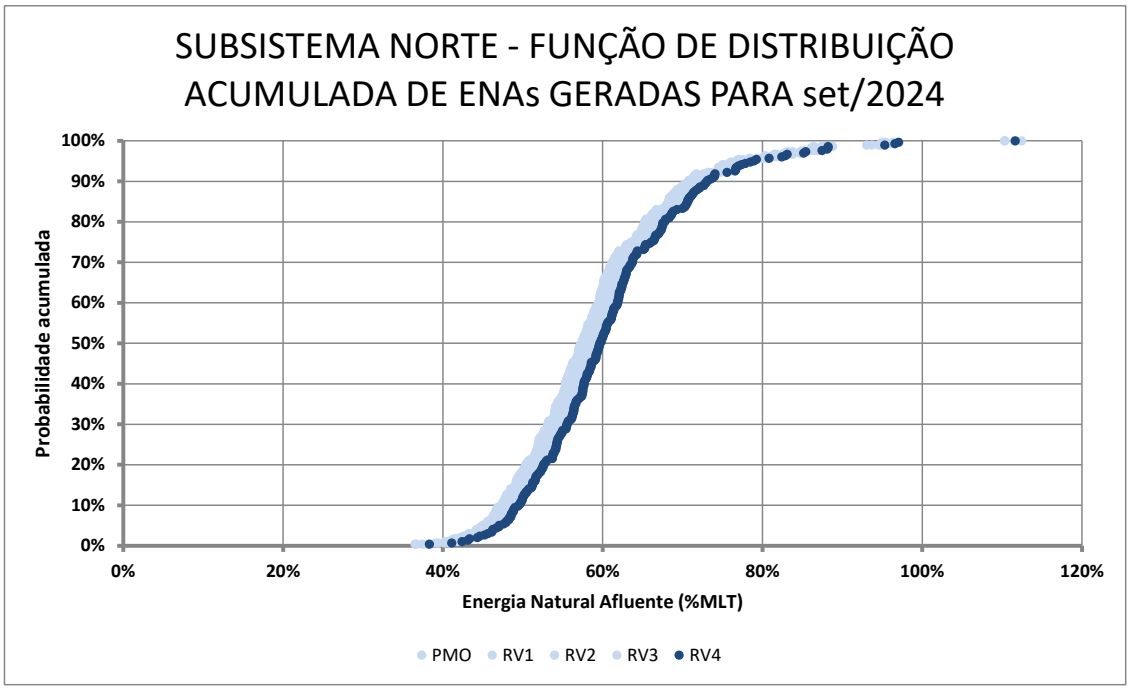

O conteúdo desta publicação foi produzido pelo ONS com base em dados e informações de conhecimento público. É de responsabilidade exclusiva dos agentes e demais interessados a obtenção de outros dados e informações, a realização de análises, estudos e avaliações para fins de tomada de decisões, definição de estratégias de atuação, assunção de compromissos e obrigações e quaisquer outras finalidades, em qualquer tempo e sob qualquer condição. É proibida a reprodução ou utilização total ou parcial do presente sem a identificação da fonte.

Os valores da MLT (Média de Longo Termo) das energias naturais afluentes para os meses de Agosto/2024 e Setembro/2024 são apresentados na tabela a seguir.

Tabela 3 – MLT da ENA nos meses de Agosto/2024 e Setembro/2024

MLT das ENAs (MWmed)		
Subsistema	agosto	setembro
SE/CO	20.521	19.627
S	10.004	11.628
NE	3.279	2.933
N	3.184	2.267

3.2. Limites de Intercâmbio entre Subsistemas

Os limites elétricos de intercâmbio de energia entre subsistemas são de fundamental importância para o processo de otimização energética, sendo determinantes para a definição das políticas de operação e do CMO para cada subsistema. Estes limites são influenciados por intervenções na malha de transmissão, notadamente na primeira semana operativa. O diagrama a seguir ilustra os fluxos notáveis do SIN e os limites aplicados neste PMO.

Figura 15 – Interligações entre regiões

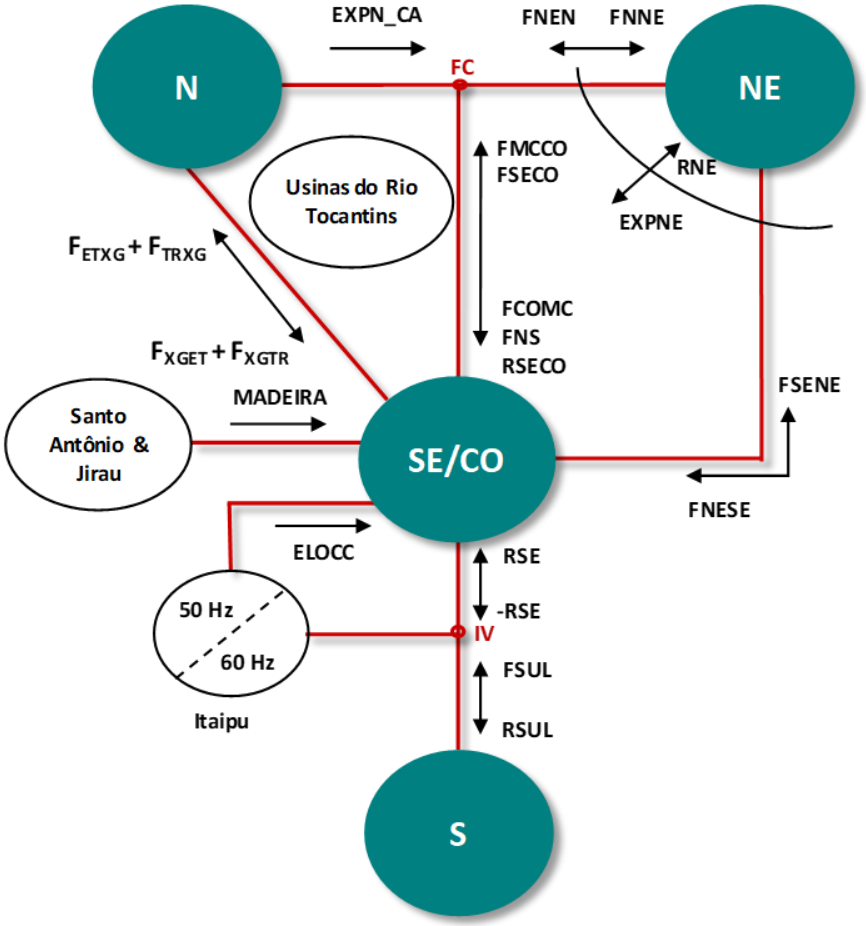

O conteúdo desta publicação foi produzido pelo ONS com base em dados e informações de conhecimento público. É de responsabilidade exclusiva dos agentes e demais interessados a obtenção de outros dados e informações, a realização de análises, estudos e avaliações para fins de tomada de decisões, definição de estratégias de atuação, assunção de compromissos e obrigações e quaisquer outras finalidades, em qualquer tempo e sob qualquer condição. É proibida a reprodução ou utilização total ou parcial do presente sem a identificação da fonte.

Tabela 4 – Limites considerados nesta semana operativa para intercâmbio de energia

Limites de Intercâmbio (MWmed)				
Fluxo	Patamar	24/08 a 30/08/2024		Demais Semanas
RNE	Pesada	11.000		11.000
	Média	11.000		11.000
	Leve	11.000		11.000
FNS	Pesada	**4.900**	(A) (B) (C)	5.100
	Média	**4.900**		5.100
	Leve	**4.584**		4.900
FNNE	Pesada	4.800		4.800
	Média	4.800		4.800
	Leve	4.800		4.800
EXPORT. NE	Pesada	11.600		11.600
	Média	11.600		11.600
	Leve	11.600		11.600
FMCCO	Pesada	5.000		5.000
	Média	5.000		5.000
	Leve	5.000		5.000
FSENE	Pesada	6.000		6.000
	Média	6.000		6.000
	Leve	6.000		6.000
FNS + FNESE	Pesada	**10.900**	(A) (B) (C)	11.100
	Média	**10.900**		11.100
	Leve	**10.784**		11.100
RSE	Pesada	**9.150**	(D) (E) (F)	9.800
	Média	**9.102**		9.800
	Leve	**10.029**		10.800
FORNEC. SUL	Pesada	7.000		7.000
	Média	7.000		7.000
	Leve	8.600		8.600

Limites de Intercâmbio (MWmed)				
Fluxo	Patamar	24/08 a 30/08/2024		Demais Semanas
RECEB. SUL	Pesada	**8.820**	(D) (E) (F)	9.600
	Média	**7.034**		7.800
	Leve	**7.251**		7.900
ELO CC 50 Hz	Pesada	**3.000**	(G)	5.481
	Média	**3.342**		5.481
	Leve	**4.458**		5.481
ITAIPU 60 Hz	Pesada	7.500		7.500
	Média	7.500		7.500
	Leve	7.500		7.500
EXP. N CA	Pesada	8.000		8.000
	Média	8.000		8.000
	Leve	8.000		8.000
FETXG + FTRXG	Pesada	4.200		4.200
	Média	2.500		2.500
	Leve	2.500		2.500
FXGET + FXGTR	Pesada	3.000		3.000
	Média	3.000		3.000
	Leve	3.000		3.000
FNESE	Pesada	8.300	(B) (C)	8.300
	Média	8.300		8.300
	Leve	**7.849**		8.300
FNEN	Pesada	4.800		4.800
	Média	4.800		4.800
	Leve	4.800		4.800
Ger_MADEIRA	Pesada	**6.018**	(H)	7.278
	Média	**6.192**		7.278
	Leve	**6.806**		7.278

(A)	SGI 27.213-24
(B)	SGI 38.263-24
(C)	SGI 00.204-24
(D)	SGI 45.280-24
(E)	SGI 46.748-24
(F)	SGI 45.299-24
(G)	SGI 47.771-24
(H)	SGI 47.787-24

O conteúdo desta publicação foi produzido pelo ONS com base em dados e informações de conhecimento público. É de responsabilidade exclusiva dos agentes e demais interessados a obtenção de outros dados e informações, a realização de análises, estudos e avaliações para fins de tomada de decisões, definição de estratégias de atuação, assunção de compromissos e obrigações e quaisquer outras finalidades, em qualquer tempo e sob qualquer condição. É proibida a reprodução ou utilização total ou parcial do presente sem a identificação da fonte.

3.3. Previsão de carga

Em junho, tanto o Monitor do PIB (FGV) quanto o Índice de Atividade Econômica (IBC-Br) apontaram um crescimento de 1,4% na margem e de 1,1% na análise trimestral em comparação ao primeiro trimestre do ano. Esse desempenho superou as expectativas do mercado e, segundo a FGV, reflete um crescimento robusto da economia brasileira, com todos os componentes da demanda em alta. Destacam-se a Formação Bruta de Capital Fixo (FBCF) e o Consumo das Famílias, que cresceram 7,3% e 5,3%, respectivamente, em relação ao mesmo período do ano anterior. No caso da FBCF, o resultado foi impulsionado pela importação de máquinas e equipamentos, sinalizando um aumento na capacidade produtiva, o que tende a favorecer o crescimento econômico futuro. Além disso, a taxa de investimento no segundo trimestre de 2024 foi de 17,8% na série a valores correntes, situando-se acima da média desde 2015 e ligeiramente abaixo da média desde 2000, conforme reportado pela FGV.

Nos subsistemas Sudeste/Centro-Oeste e Sul, a semana em curso apresentou temperaturas mais elevadas em relação à anterior, o que impactou positivamente a dinâmica da carga. Para a próxima semana, a expectativa é de uma diminuição das temperaturas máximas e de precipitação no início da semana operativa em ambos os subsistemas.

Para os subsistemas Nordeste e Norte, não são esperadas mudanças significativas para a próxima semana, com previsão de temperaturas estáveis e manutenção do cenário de precipitação em grande parte das regiões, típicos para esta época do ano.

Assim, os novos valores de carga previstos para o mês de agosto/2024, indicam taxas de crescimento de 1,7% no subsistema Sudeste/Centro-Oeste, 6,5% no subsistema Sul, 9,0% no subsistema Nordeste e 7,2% no subsistema Norte.

Tabela 5 – Evolução da carga do PMO de Agosto de 2024

Subsistema	CARGA SEMANAL (MWmed)						CARGA MENSAL (MWmed)	
	1ª Sem	2ª Sem	3ª Sem	4ª Sem	5ª Sem	6ª Sem	ago/24	Var. (%) ago/24 -> ago/23
SE/CO	41.643	42.830	40.225	43.834	41.800	42.378	42.145	1,7%
Sul	12.814	13.057	12.831	13.523	12.991	13.150	13.084	6,5%
Nordeste	12.790	12.630	12.861	13.010	13.083	13.013	12.893	9,0%
Norte	7.928	8.003	7.938	8.145	8.144	8.111	8.051	7,2%
SIN	**75.175**	**76.520**	**73.855**	**78.512**	**76.018**	**76.652**	**76.173**	**4,3%**

O conteúdo desta publicação foi produzido pelo ONS com base em dados e informações de conhecimento público. É de responsabilidade exclusiva dos agentes e demais interessados a obtenção de outros dados e informações, a realização de análises, estudos e avaliações para fins de tomada de decisões, definição de estratégias de atuação, assunção de compromissos e obrigações e quaisquer outras finalidades, em qualquer tempo e sob qualquer condição. É proibida a reprodução ou utilização total ou parcial do presente sem a identificação da fonte.

3.4. Potência Hidráulica Total Disponível no SIN

O gráfico a seguir mostra a disponibilidade hidráulica total do SIN, para este mês, de acordo com o cronograma de manutenção informado pelos agentes para esta Revisão.

Figura 16 – Potência hidráulica disponível no SIN

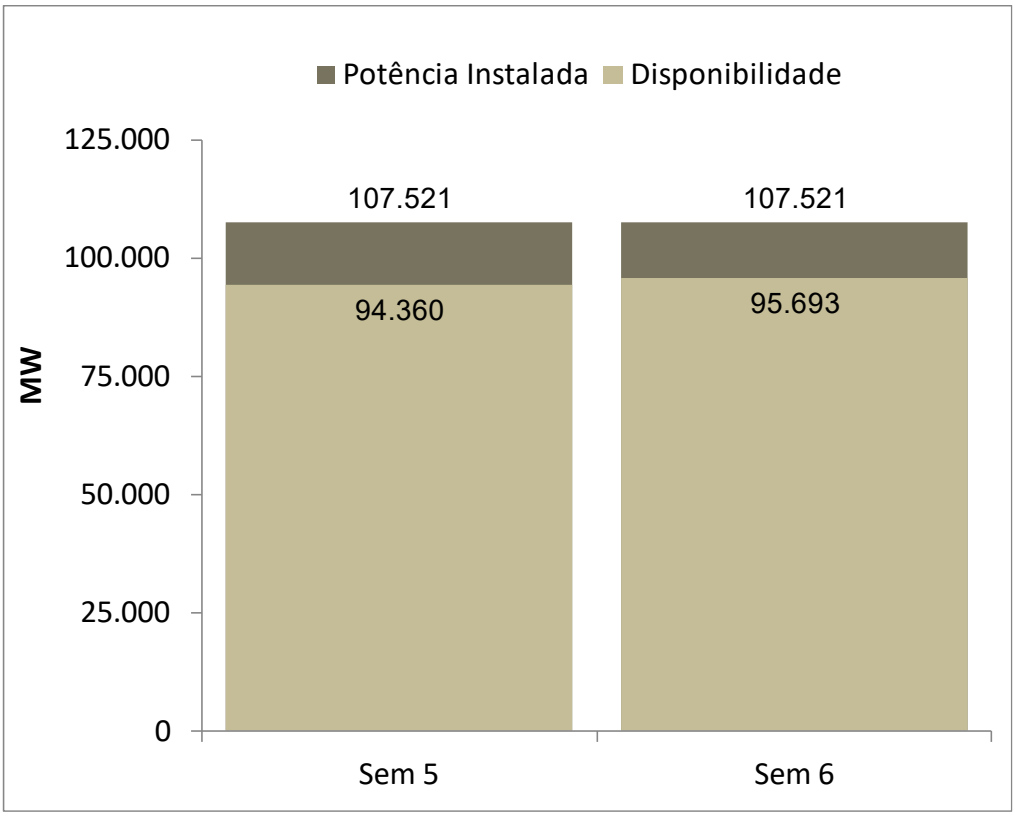

3.5. Armazenamentos Iniciais por Subsistema

Tabela 6 – Armazenamentos iniciais, por subsistema, considerados para esta semana operativa

Armazenamento (%EARmáx) - 0:00 h do dia 24/08/2024		
Subsistema	**Nível previsto na Revisão 3 do PMO Ago/2024**	**Partida informada pelos Agentes para a Revisão 4 do PMO Ago/2024**
SE/CO	57,4	57,5
S	74,7	72,5
NE	58,0	57,6
N	80,9	80,4

A primeira coluna da tabela acima corresponde ao armazenamento previsto na Revisão 3 do PMO de Agosto de 2024, para a 0:00 h do dia 24/08/2024. A segunda coluna apresenta os armazenamentos obtidos a partir dos níveis de partida informados pelos Agentes de Geração para seus aproveitamentos com reservatórios.

O conteúdo desta publicação foi produzido pelo ONS com base em dados e informações de conhecimento público. É de responsabilidade exclusiva dos agentes e demais interessados a obtenção de outros dados e informações, a realização de análises, estudos e avaliações para fins de tomada de decisões, definição de estratégias de atuação, assunção de compromissos e obrigações e quaisquer outras finalidades, em qualquer tempo e sob qualquer condição. É proibida a reprodução ou utilização total ou parcial do presente sem a identificação da fonte.

4. PRINCIPAIS RESULTADOS

4.1. Política de Operação Energética

Para esta semana operativa, está prevista a seguinte política de intercâmbio de energia entre regiões:

Região SE/CO:

- Utilização dos recursos das bacias dos rios Grande, Paranaíba e Paraná, conforme necessidade de alocação na carga média e pesada e controle de nível;

- Minimização dos recursos do Tietê e Paranapanema para evitar impacto em restrições de operação;

- Minimização na utilização dos recursos das usinas do AC/RO;

Região Sul:

- Exploração da geração hidráulica nas bacias do Jacuí, Uruguai e Iguaçu de acordo com a possibilidade de alocação em todos os períodos de carga;

Região NE:

- Minimização na média diária do recurso da bacia do São Francisco e modulando para atendimento à ponta de carga;

- Perfil exportador de energia em todos os patamares de carga devido EOL/UFV;

Região Norte:

- Utilização da geração da usina de Belo Monte para atendimento à ponta de carga, conforme disponibilidade energética;

- Operação minimizada nas usinas do Norte conforme comando do CMSE;

4.2. Custo Marginal de Operação – CMO

A figura a seguir apresenta os Custos Marginais de Operação, em valores médios semanais, para as semanas operativas deste mês.

Figura 17 – CMO em valores médios

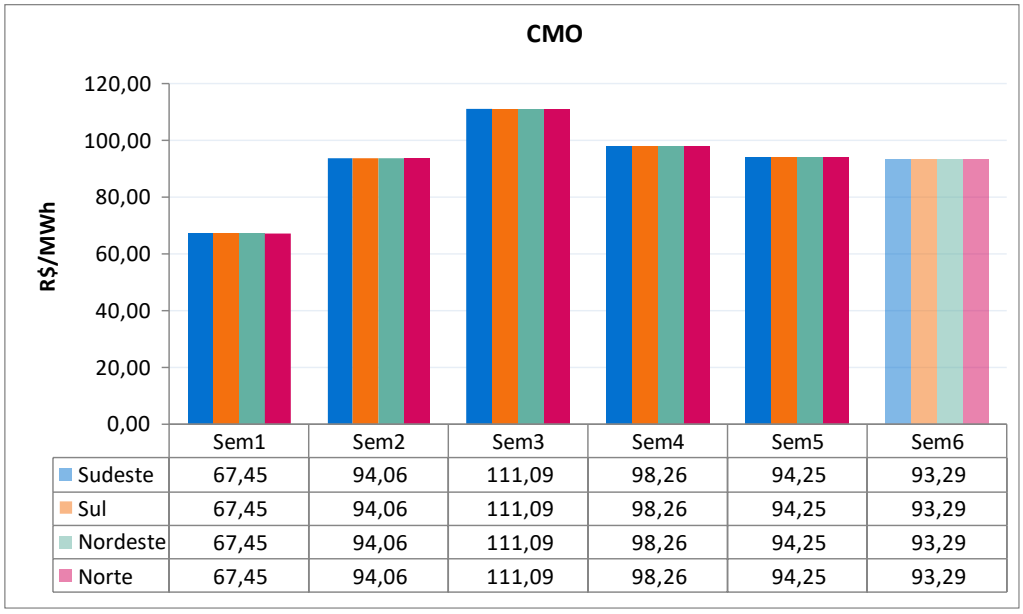

	Sem1	Sem2	Sem3	Sem4	Sem5	Sem6
Sudeste	67,45	94,06	111,09	98,26	94,25	93,29
Sul	67,45	94,06	111,09	98,26	94,25	93,29
Nordeste	67,45	94,06	111,09	98,26	94,25	93,29
Norte	67,45	94,06	111,09	98,26	94,25	93,29

O conteúdo desta publicação foi produzido pelo ONS com base em dados e informações de conhecimento público. É de responsabilidade exclusiva dos agentes e demais interessados a obtenção de outros dados e informações, a realização de análises, estudos e avaliações para fins de tomada de decisões, definição de estratégias de atuação, assunção de compromissos e obrigações e quaisquer outras finalidades, em qualquer tempo e sob qualquer condição. É proibida a reprodução ou utilização total ou parcial do presente sem a identificação da fonte.

A tabela a seguir apresenta o custo marginal de operação, por subsistema e patamar de carga, para a próxima semana operativa.

Tabela 7 – CMO para esta semana operativa

Patamares de Carga	CMO (R$/MWh)			
	SE/CO	S	NE	N
Pesada	97,27	97,27	97,27	97,27
Média	94,23	94,23	94,23	94,23
Leve	93,14	93,14	93,14	93,14
Média Semanal	94,25	94,25	94,25	94,25

4.3. Energia Armazenada

O processo de otimização realizado pelo programa DECOMP indicou os armazenamentos mostrados na figura a seguir para as próximas semanas operativas do mês de agosto/2024.

Figura 18 – Energias Armazenadas nas semanas operativas do mês de agosto/2024.

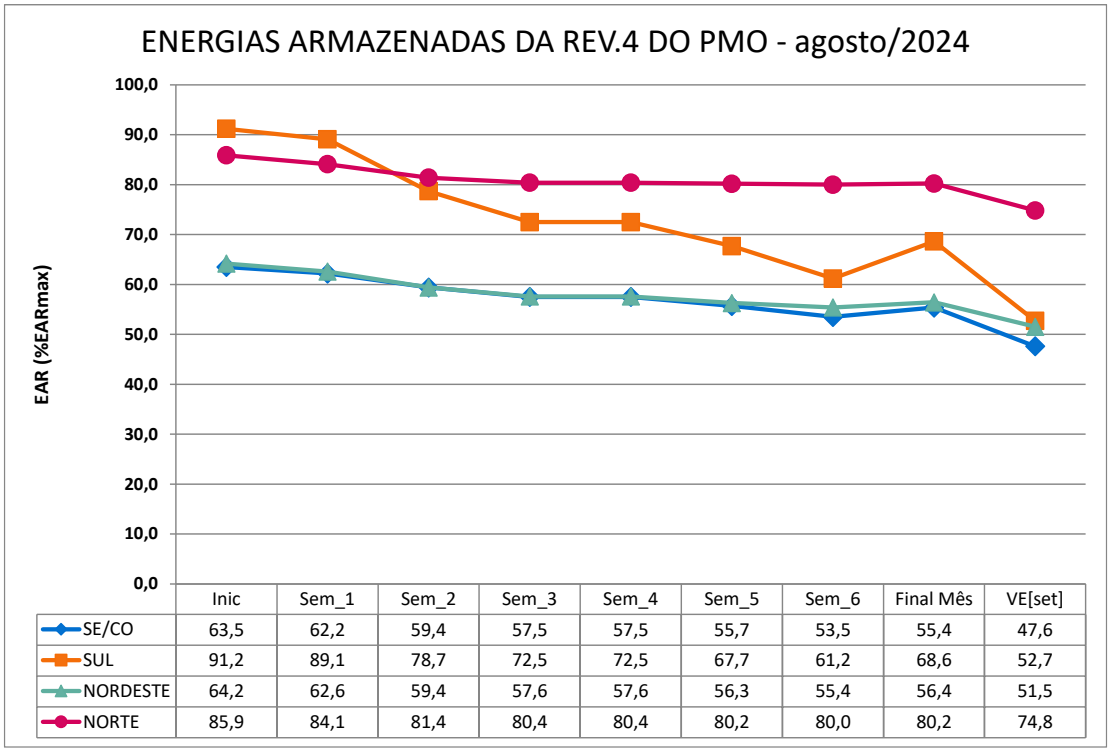

	Inic	Sem_1	Sem_2	Sem_3	Sem_4	Sem_5	Sem_6	Final Mês	VE[set]
SE/CO	63,5	62,2	59,4	57,5	57,5	55,7	53,5	55,4	47,6
SUL	91,2	89,1	78,7	72,5	72,5	67,7	61,2	68,6	52,7
NORDESTE	64,2	62,6	59,4	57,6	57,6	56,3	55,4	56,4	51,5
NORTE	85,9	84,1	81,4	80,4	80,4	80,2	80,0	80,2	74,8

Os armazenamentos da figura anterior estão expressos em percentual da Energia Armazenável Máxima de cada subsistema, que são mostradas na tabela a seguir.

Tabela 8 – Energia Armazenável Máxima por subsistema no PMO de agosto/2024.

ENERGIA ARMAZENÁVEL MÁXIMA (MWmed)		
Subsistema	agosto	setembro
SE/CO	205.460	205.460
S	20.458	20.458
NE	51.718	51.718
N	15.689	15.711

O conteúdo desta publicação foi produzido pelo ONS com base em dados e informações de conhecimento público. É de responsabilidade exclusiva dos agentes e demais interessados a obtenção de outros dados e informações, a realização de análises, estudos e avaliações para fins de tomada de decisões, definição de estratégias de atuação, assunção de compromissos e obrigações e quaisquer outras finalidades, em qualquer tempo e sob qualquer condição. É proibida a reprodução ou utilização total ou parcial do presente sem a identificação da fonte.

5. GERAÇÃO TÉRMICA

A Figura 19 apresenta, para cada subsistema do SIN, o despacho térmico por modalidade indicado pelo Decomp para esta semana operativa.

Figura 19 – Geração térmica para a próxima semana operativa

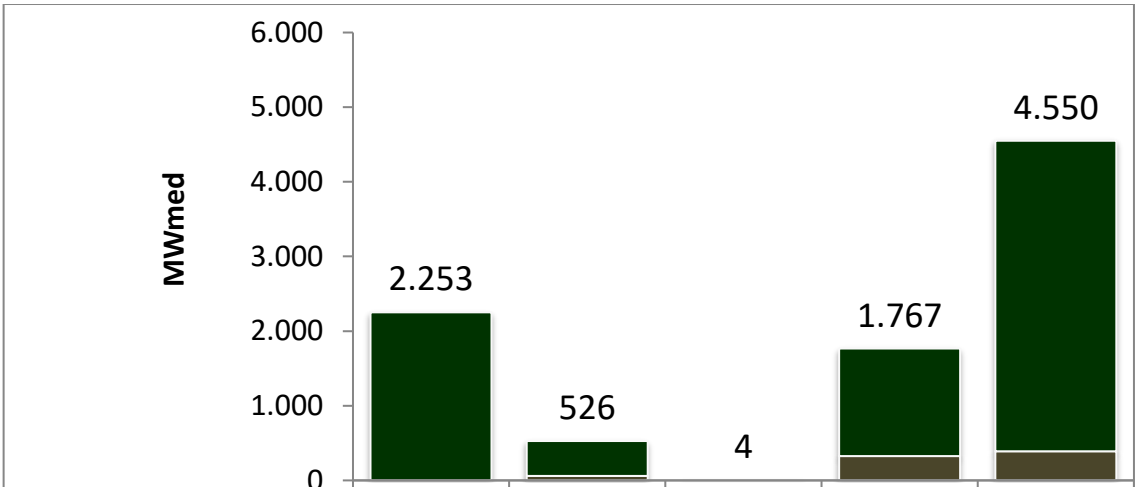

	SE/CO	SUL	NE	NORTE	SIN
TOTAL	2.253	526	4	1.767	4.550
RESTRIÇÃO ELÉTRICA	0	0	0	0	0
INFLEXIBILIDADE	2253	464	4	1440	4161
ORDEM DE MÉRITO	0	62	0	327	389

Na tabela abaixo segue a Indicação de despacho antecipado por ordem de mérito de custo para a semana de 26/10/2024 a 01/11/2024.

Tabela 9 – UTEs com contrato de combustível GNL

UTE			Benefício (R$/MWh)		
Nome	Cod	CVU (R$/MWh)	Carga Pesada	Carga Média	Carga Leve
SANTA CRUZ	86	139,95	87,6 (2)	87,6 (2)	87,56 (2)
LUIZORMELO	15	205,18	87,6 (2)	87,6 (2)	87,56 (2)
PSERGIPE I	224	393,06	87,6 (2)	87,6 (2)	87,56 (2)

(1) Comandado o despacho antecipado por ordem de mérito de custo nesse patamar
(2) NÃO foi comandado o despacho antecipado por ordem de mérito de custo nesse patamar

Assim sendo, não há previsão de despacho antecipado por ordem de mérito de custo para as UTE Santa Cruz, Luiz O. R. Melo e Porto Sergipe I, para a semana de 26/10/2024 a 01/11/2024.

O conteúdo desta publicação foi produzido pelo ONS com base em dados e informações de conhecimento público. É de responsabilidade exclusiva dos agentes e demais interessados a obtenção de outros dados e informações, a realização de análises, estudos e avaliações para fins de tomada de decisões, definição de estratégias de atuação, assunção de compromissos e obrigações e quaisquer outras finalidades, em qualquer tempo e sob qualquer condição. É proibida a reprodução ou utilização total ou parcial do presente sem a identificação da fonte.

6. IMPORTAÇÃO DE ENERGIA

6.1. República Oriental do Uruguai

Para a próxima semana operativa, foi declarada a seguinte oferta de importação de energia da República Oriental do Uruguai para o Sistema Interligado Nacional - SIN através da conversora de Melo (500 MW).

- **Enel**

Tabela 10 – Energia ofertada para importação

	Oferta de Energia para a Semana de 24/08 a 30/08 (MWmed)						
	Bloco 1	Bloco 2	Bloco 3	Bloco 4	Bloco 5	Bloco 6	Total
Carga Pesada	50	50	25	25	50	50	250
Carga Média	50	50	25	25	50	50	250
Carga Leve	50	50	25	25	50	50	250
CVU (R$/MWh)	568,46	870,36	1.371,22	1.641,96	1.899,15	2.020,98	

- **BTG Pactual**

Tabela 11 – Energia ofertada para importação

	Oferta de Energia para a Semana de 24/08 a 30/08 (MWmed)						
	Bloco 1	Bloco 2	Bloco 3	Bloco 4	Bloco 5	Bloco 6	Total
Carga Pesada	50	50	25	25	50	50	250
Carga Média	50	50	25	25	50	50	250
Carga Leve	50	50	25	25	50	50	250
CVU (R$/MWh)	574,84	883,36	1.390,69	1.664,93	1.925,45	2.048,85	

6.2. República da Argentina

Para a próxima semana operativa, foi declarada a seguinte oferta de importação de energia da República da Argentina para o SIN através das conversoras de Garabi 1 (1.100 MW) e Garabi 2 (1.100 MW).

- **Enel**

Tabela 12 – Energia ofertada para importação

	Oferta de Energia para a Semana de 24/08 a 30/08 (MWmed)				
	Bloco 1	Bloco 2	Bloco 3	Bloco 4	Total
Carga Pesada	500	500	500	500	2000
Carga Média	500	500	500	500	2000
Carga Leve	500	500	500	500	2000
CVU (R$/MWh)	838,12	1.171,14	1.437,56	1.637,38	

Nota: Detalhes sobre a importação de energia vide Portaria Normativa Nº 60/GM/MME, de 29 de dezembro de 2022 disponível em: https://www.in.gov.br/en/web/dou/-/portaria-normativa-n-60/gm/mme-de-29-de-dezembro-de-2022-454963353

O conteúdo desta publicação foi produzido pelo ONS com base em dados e informações de conhecimento público. É de responsabilidade exclusiva dos agentes e demais interessados a obtenção de outros dados e informações, a realização de análises, estudos e avaliações para fins de tomada de decisões, definição de estratégias de atuação, assunção de compromissos e obrigações e quaisquer outras finalidades, em qualquer tempo e sob qualquer condição. É proibida a reprodução ou utilização total ou parcial do presente sem a identificação da fonte.

7. ESTIMATIVA DE ENCARGOS OPERATIVOS

As figuras a seguir apresentam um resumo dos resultados da Revisão 4 de Agosto/2024, com informações da Energia Natural Afluente (ENA), da Energia Armazenada (EAR) e do Custo Marginal de Operação (CMO) nos subsistemas do Sistema Interligado Nacional (SIN). São apresentados os valores semanais observados e previstos e o valor esperado dos cenários gerados para o mês de setembro/2024.

Figura 20 – Resumo de gosto/2024 para o Subsistema Sudeste/Centro-Oeste

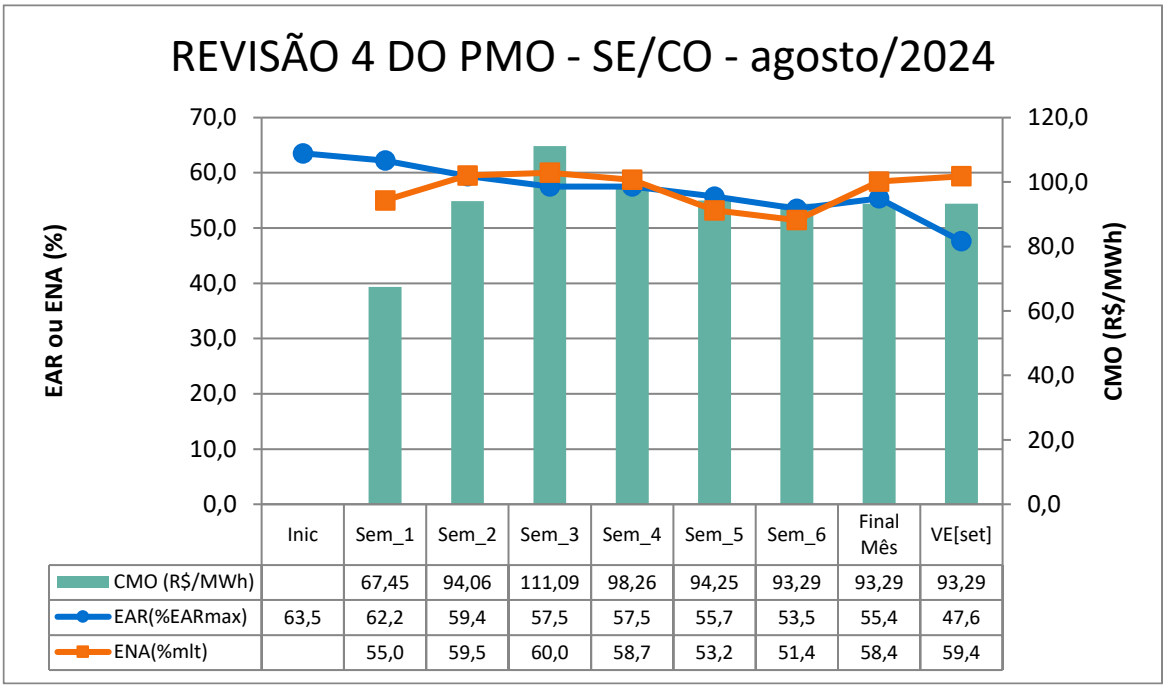

	Inic	Sem_1	Sem_2	Sem_3	Sem_4	Sem_5	Sem_6	Final Mês	VE[set]
CMO (R$/MWh)		67,45	94,06	111,09	98,26	94,25	93,29	93,29	93,29
EAR(%EARmax)	63,5	62,2	59,4	57,5	57,5	55,7	53,5	55,4	47,6
ENA(%mlt)		55,0	59,5	60,0	58,7	53,2	51,4	58,4	59,4

Figura 21 – Resumo de agosto/2024 para o Subsistema Sul

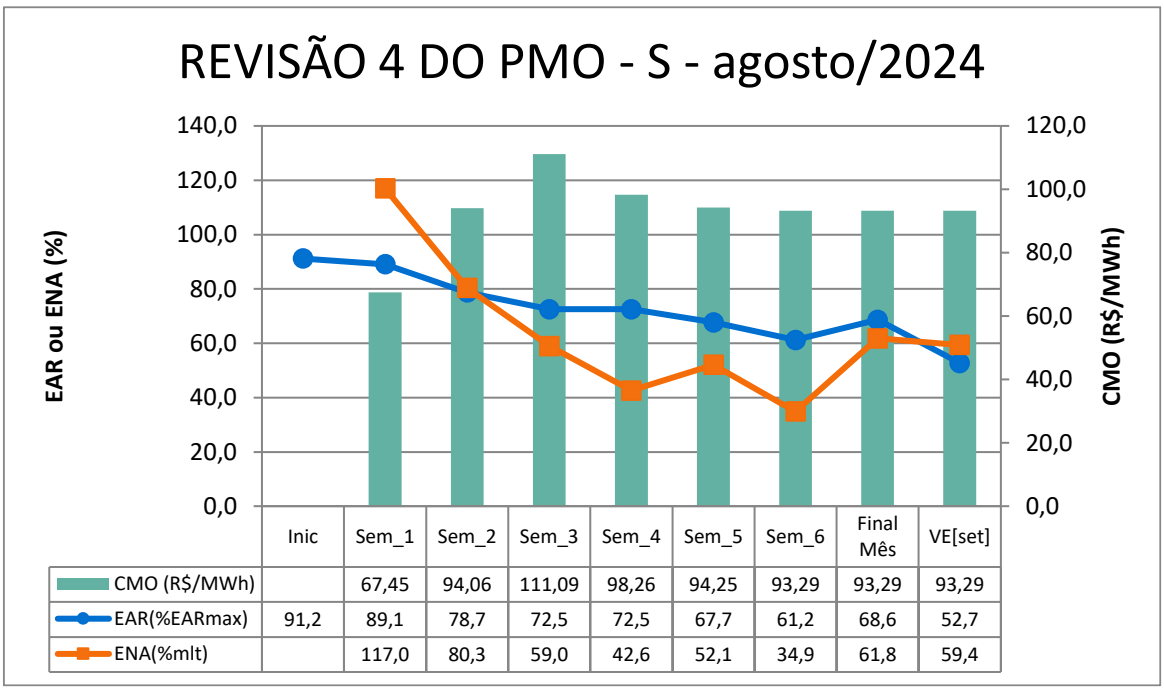

	Inic	Sem_1	Sem_2	Sem_3	Sem_4	Sem_5	Sem_6	Final Mês	VE[set]
CMO (R$/MWh)		67,45	94,06	111,09	98,26	94,25	93,29	93,29	93,29
EAR(%EARmax)	91,2	89,1	78,7	72,5	72,5	67,7	61,2	68,6	52,7
ENA(%mlt)		117,0	80,3	59,0	42,6	52,1	34,9	61,8	59,4

O conteúdo desta publicação foi produzido pelo ONS com base em dados e informações de conhecimento público. É de responsabilidade exclusiva dos agentes e demais interessados a obtenção de outros dados e informações, a realização de análises, estudos e avaliações para fins de tomada de decisões, definição de estratégias de atuação, assunção de compromissos e obrigações e quaisquer outras finalidades, em qualquer tempo e sob qualquer condição. É proibida a reprodução ou utilização total ou parcial do presente sem a identificação da fonte.

Figura 22 – Resumo de agosto/2024 para o Subsistema Nordeste

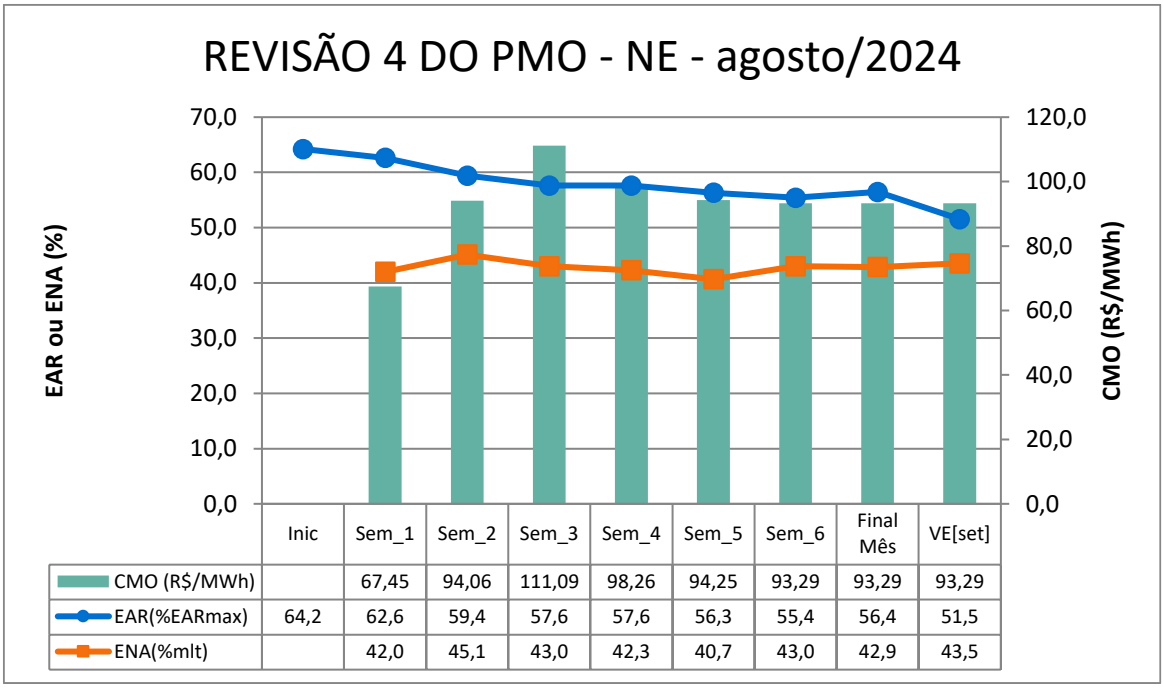

	Inic	Sem_1	Sem_2	Sem_3	Sem_4	Sem_5	Sem_6	Final Mês	VE[set]
CMO (R$/MWh)		67,45	94,06	111,09	98,26	94,25	93,29	93,29	93,29
EAR(%EARmax)	64,2	62,6	59,4	57,6	57,6	56,3	55,4	56,4	51,5
ENA(%mlt)		42,0	45,1	43,0	42,3	40,7	43,0	42,9	43,5

Figura 23 – Resumo de agosto/2024 para o Subsistema Norte

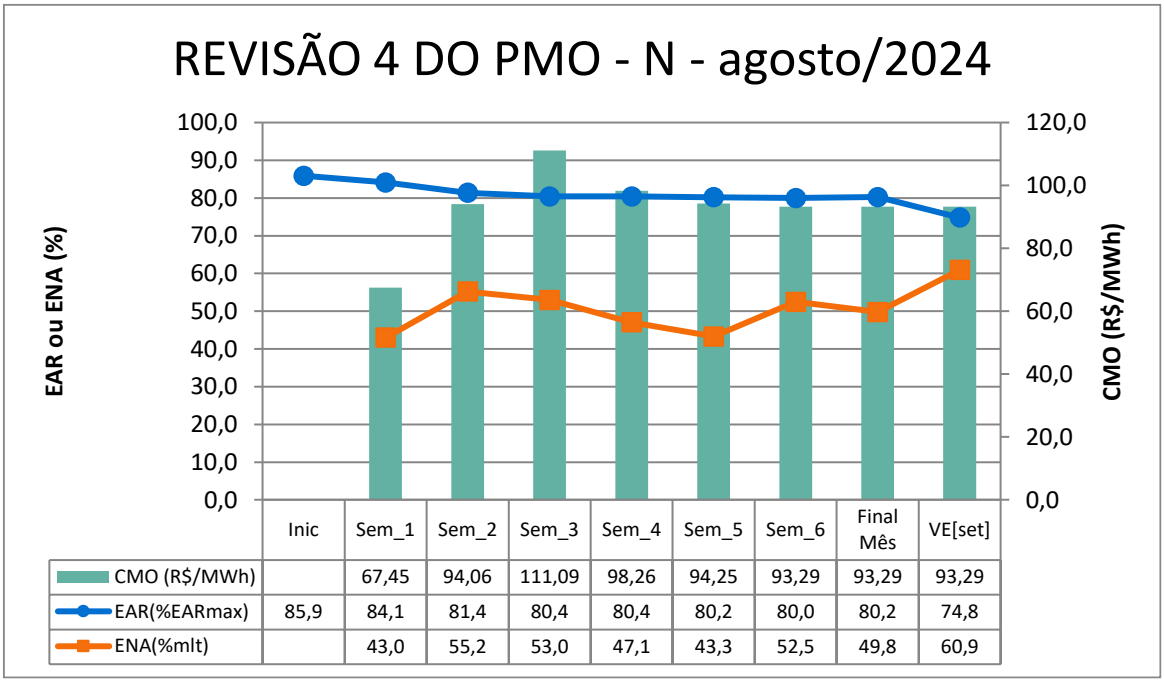

	Inic	Sem_1	Sem_2	Sem_3	Sem_4	Sem_5	Sem_6	Final Mês	VE[set]
CMO (R$/MWh)		67,45	94,06	111,09	98,26	94,25	93,29	93,29	93,29
EAR(%EARmax)	85,9	84,1	81,4	80,4	80,4	80,2	80,0	80,2	74,8
ENA(%mlt)		43,0	55,2	53,0	47,1	43,3	52,5	49,8	60,9

O conteúdo desta publicação foi produzido pelo ONS com base em dados e informações de conhecimento público. É de responsabilidade exclusiva dos agentes e demais interessados a obtenção de outros dados e informações, a realização de análises, estudos e avaliações para fins de tomada de decisões, definição de estratégias de atuação, assunção de compromissos e obrigações e quaisquer outras finalidades, em qualquer tempo e sob qualquer condição. É proibida a reprodução ou utilização total ou parcial do presente sem a identificação da fonte.

8. ARMAZENAMENTOS OPERATIVOS

Para uma melhor avaliação de diversos cenários hidrometeorológicos, notadamente, aqueles de curto prazo e suas influências nas previsões de vazões nos subsistemas, os resultados desta Revisão do PMO contemplam cenários de afluências visando melhor representar a ocorrência de precipitação e, consequentemente, seus efeitos sobre as afluências e armazenamentos.

Apresentamos a seguir as correspondentes energias naturais afluentes e os resultados obtidos com a aplicação do cenário de afluência utilizado no estudo.

Tabela 13 – Previsão de ENA do caso de valor esperado das previsões de afluência

Subsistema	ENERGIAS NATURAIS AFLUENTES			
	Previsão Semanal		Previsão Mensal	
	(MWmed)	%MLT	(MWmed)	%MLT
SE/CO	10.924	53	11.990	58
Sul	5.209	52	6.187	62
Nordeste	1.333	41	1.405	43
Norte	1.352	42	1.585	50

Tabela 14 – Previsão de %EARmáx para o final do mês

Subsistema	% EARmáx 23/08	% EARmáx - 31/08
	NÍVEL INICIAL	NÍVEL PMO
SE/CO	57,5	55,4
Sul	72,5	66,8
Nordeste	57,6	56,2
Norte	80,4	80,2

O conteúdo desta publicação foi produzido pelo ONS com base em dados e informações de conhecimento público. É de responsabilidade exclusiva dos agentes e demais interessados a obtenção de outros dados e informações, a realização de análises, estudos e avaliações para fins de tomada de decisões, definição de estratégias de atuação, assunção de compromissos e obrigações e quaisquer outras finalidades, em qualquer tempo e sob qualquer condição. É proibida a reprodução ou utilização total ou parcial do presente sem a identificação da fonte.

9. RESERVATÓRIOS EQUIVALENTES DE ENERGIA

A seguir são apresentadas as previsões de Energia Natural Afluente para a próxima semana operativa e para o mês de agosto, bem como as previsões de Energia Armazenada nos Reservatórios Equivalentes de Energia – REE, desta Revisão do PMO de Agosto de 2024.

Tabela 15 – Previsão de ENA por REE

Valor Esperado das Energias Naturais Afluentes				
REE	Previsão Semanal		Previsão Mensal	
	24/08/2024 a 30/08/2024		ago/24	
	(MWmed)	%MLT	(MWmed)	%MLT
Sudeste	1.406	56	1.639	66
Madeira	1.142	48	1.363	57
Teles Pires	467	59	512	65
Itaipu	1.580	60	1.695	65
Paraná	5.514	53	5.974	58
Paranapanema	807	43	798	43
Sul	3.203	54	3.302	55
Iguaçu	2.006	50	2.885	72
Nordeste	1.333	41	1.406	43
Norte	900	49	1.016	56
Belo Monte	113	17	166	25
Manaus	366	53	452	66

Tabela 16 – Previsão de %EARmáx por REE

% Energia Armazenável Máxima		
REE	Previsão Semanal	Previsão Mensal
	30-ago	31-ago
	(%EARmáx)	(%EARmáx)
Sudeste	64,5	64,2
Madeira	39,3	38,9
Teles Pires	50,9	50,2
Itaipu	87,6	89,4
Paraná	53,3	52,9
Paranapanema	45,2	45,1
Sul	66,9	66,1
Iguaçu	68,5	67,5
Nordeste	56,3	56,2
Norte	83,1	83,1
Belo Monte	71,0	72,3
Manaus	25,9	25,7

O conteúdo desta publicação foi produzido pelo ONS com base em dados e informações de conhecimento público. É de responsabilidade exclusiva dos agentes e demais interessados a obtenção de outros dados e informações, a realização de análises, estudos e avaliações para fins de tomada de decisões, definição de estratégias de atuação, assunção de compromissos e obrigações e quaisquer outras finalidades, em qualquer tempo e sob qualquer condição. É proibida a reprodução ou utilização total ou parcial do presente sem a identificação da fonte.

10. DESPACHO TÉRMICO POR MODALIDADE, PATAMAR DE CARGA E USINA

Nas tabelas abaixo, a diferenciação entre geração por inflexibilidade e por ordem de mérito tem caráter informativo, com o objetivo de detalhar a informação de inflexibilidade enviada pelos respectivos agentes para esta Revisão do PMO. Ressalta-se que nas etapas de Programação Diária e Tempo Real, o montante despachado nas usinas termelétricas indicadas por ordem de mérito é plenamente intitulado como ordem de mérito.

REGIÃO SUDESTE/CENTRO-OESTE																	
Térmicas Potência (MW)	Combustível	CVU	Inflexibilidade			Ordem de Mérito			Total Mérito e INFL.			Razão Elétrica			Total UTE		
			P	M	L	P	M	L	P	M	L	P	M	L	P	M	L
ATLAN_CSA (255)	Resíduos	0,00															
DAIA (44)	Diesel	---															
TNORTE 2 (349)	Óleo	---															
W.ARJONA (177)	Gás	---															
W.ARJONA O	Diesel	---															
XAVANTES (54)	Diesel	---															
ANGRA 2 (1350)	Nuclear	20,12	1350,0	1350,0	1350,0	0,0	0,0	0,0	1350,0	1350,0	1350,0				1350,0	1350,0	1350,0
ANGRA 1 (640)	Nuclear	31,17	640,0	640,0	640,0	0,0	0,0	0,0	640,0	640,0	640,0				640,0	640,0	640,0
NORTEFLU 1 (400)	Gás	111,91															
NORTEFLU 2 (100)	Gás	128,33															
BAIXADA FL (530)	Gás	137,08															
O.PINTADA (50)	Biomassa	138,91															
SANTA CRUZ (500)	GNL	139,95															
UTE STA VI (41)	Biomassa	150,06	18,0	18,0	18,0				18,0	18,0	18,0				18,0	18,0	18,0
M.AZUL (566)	Gás	177,29															
LUIZORMELO (204)	GNL	205,18															
NORTEFLU 3 (200)	Gás	247,09															
ATLANTICO (235)	Resíduos	248,36	199,6	199,6	199,6				199,6	199,6	199,6				199,6	199,6	199,6
UTE GNA I (1338)	Gás	259,75															
ST.CRUZ 34 (436)	Óleo	310,41															
TERMORIO (989)	Gás	406,85															
CUBATAO (216)	Gás	430,23															
PIRAT.12 O (200)	Gás	470,34															
IBIRITE (235)	Gás	592,87															
T.LAGOAS (350)	Gás	720,02															
NORTEFLU 4 (127)	Gás	763,12															
J.FORA (87)	Gás	833,42															
KARKEY 013 (259)	Gás	863,56	30,0	30,0	30,0				30,0	30,0	30,0				30,0	30,0	30,0
KARKEY 019 (116)	Gás	863,56															
SEROPEDICA (360)	Gás	893,41															
T.MACAE (929)	Gás	931,09															
NPIRATINGA (572)	Gás	951,71															
PORSUD II (78)	Gás	1011,33															
PORSUD I (116)	Gás	1012,00															
CUIABA CC (529)	Gás	1033,02															
LORM_PCS (36)	Gás	1196,80															
POVOACAO I (75)	Gás	1196,80															
VIANA I (37)	Gás	1196,80															
VIANA (175)	Óleo	1197,80															
PAULINIA (16)	Gás	1234,24	15,7	15,7	15,7				15,7	15,7	15,7				15,7	15,7	15,7
PALMEIR_GO (176)	Diesel	1730,87															
TOTAL SE/CO (13147)			2253,3	2253,3	2253,3	0,0	0,0	0,0	2253,3	2253,3	2253,3	0,0	0,0	0,0	2253,3	2253,3	2253,3

O conteúdo desta publicação foi produzido pelo ONS com base em dados e informações de conhecimento público. É de responsabilidade exclusiva dos agentes e demais interessados a obtenção de outros dados e informações, a realização de análises, estudos e avaliações para fins de tomada de decisões, definição de estratégias de atuação, assunção de compromissos e obrigações e quaisquer outras finalidades, em qualquer tempo e sob qualquer condição. É proibida a reprodução ou utilização total ou parcial do presente sem a identificação da fonte.

REGIÃO SUL

Térmicas Potência (MW)	Combustível	CVU	Inflexibilidade			Ordem de Mérito			Total Mérito e INFL.			Razão Elétrica			Total UTE		
			P	M	L	P	M	L	P	M	L	P	M	L	P	M	L
ARAUCARIA (484)	Gás	---															
URUGUAIANA (640)	Gás	---															
PAMPA SUL (345)	Carvão	96,61				345,0			345,0						345,0	0,0	0,0
SAO SEPE (8)	Biomassa	108,38															
CANDIOTA_3 (350)	Carvão	111,48															
J.LACER. C (330)	Carvão	325,27	300,0	300,0	300,0				300,0	300,0	300,0				300,0	300,0	300,0
FIGUEIRA (20)	Carvão	330,64															
J.LACER. B (220)	Carvão	378,90															
J.LAC. A2 (110)	Carvão	387,75	100,0	100,0	100,0				100,0	100,0	100,0				100,0	100,0	100,0
J.LAC. A1 (80)	Carvão	453,14	60,0	60,0	60,0				60,0	60,0	60,0				60,0	60,0	60,0
B.BONITA I (10)	Gás	742,99	3,7	3,7	3,7				3,7	3,7	3,7				3,7	3,7	3,7
CANOAS (249)	Gás	1129,76															
TOTAL SUL (2846)			463,7	463,7	463,7	345,0	0,0	0,0	808,7	463,7	463,7	0,0	0,0	0,0	808,7	463,7	463,7

REGIÃO NORDESTE

Térmicas Potência (MW)	Combustível	CVU	Inflexibilidade			Ordem de Mérito			Total Mérito e INFL.			Razão Elétrica			Total UTE		
			P	M	L	P	M	L	P	M	L	P	M	L	P	M	L
PETROLINA (136)	Óleo	---															
POTIGUAR (53)	Diesel	---															
POTIGUAR_3 (66)	Diesel	---															
TERMOPE (550)	Gás	---															
ERB CANDEI (17)	Biomassa	108,45	3,5	3,5	3,5				3,5	3,5	3,5				3,5	3,5	3,5
PROSP_I (28)	Gás	204,55															
PROSP_III (56)	Gás	208,41															
PROSP_II (37)	Gás	322,28															
P.PECEM1 (720)	Carvão	342,35															
P.PECEM2 (365)	Carvão	348,87															
PSERGIPE I (1593)	GNL	393,06															
VALE ACU (368)	Gás	450,86															
T.BAHIA (186)	Gás	530,51															
TERMOCEARA (223)	Gás	563,26															
PERNAMBU_3 (201)	Óleo	1033,97															
MARACANAU (168)	Óleo	1165,84															
TERMOCABO (50)	Óleo	1183,07															
TERMONE (171)	Óleo	1186,96															
TERMOPB (171)	Óleo	1186,96															
CAMPINA_GR (169)	Óleo	1197,82															
SUAPE II (381)	Óleo	1226,53															
GLOBAL I (149)	Óleo	1356,93															
GLOBAL II (149)	Óleo	1356,93															
TOTAL NE (6007)			3,5	3,5	3,5	0,0	0,0	0,0	3,5	3,5	3,5	0,0	0,0	0,0	3,5	3,5	3,5

REGIÃO NORTE

Térmicas Potência (MW)	Combustível	CVU	Inflexibilidade			Ordem de Mérito			Total Mérito e INFL.			Razão Elétrica			Total UTE		
			P	M	L	P	M	L	P	M	L	P	M	L	P	M	L
C. ROCHA (85)	Gás	0,00	65,0	65,0	65,0				65,0	65,0	65,0				65,0	65,0	65,0
JARAQUI (75)	Gás	0,00	63,0	63,0	63,0				63,0	63,0	63,0				63,0	63,0	63,0
MANAUARA (73)	Gás	0,00	47,0	48,1	51,0				47,0	48,1	51,0				47,0	48,1	51,0
PONTA NEGR (73)	Gás	0,00	64,0	64,0	64,0				64,0	64,0	64,0				64,0	64,0	64,0
TAMBAQUI (93)	Gás	0,00	63,0	63,0	63,0				63,0	63,0	63,0				63,0	63,0	63,0
APARECIDA (166)	Gás	78,41	74,0	74,0	74,0	0,0	0,0	0,0	74,0	74,0	74,0				74,0	74,0	74,0
UTE MAUA 3 (591)	Gás	78,41	264,0	264,0	264,0	326,8	326,8	326,8	590,8	590,8	590,8				590,8	590,8	590,8
MARANHAO3 (519)	Gás	105,87	490,0	490,0	490,0				490,0	490,0	490,0				490,0	490,0	490,0
MARANHAO V (338)	Gás	131,48	75,0	75,0	75,0				75,0	75,0	75,0				75,0	75,0	75,0
MARANHAOIV (338)	Gás	131,48	75,0	75,0	75,0				75,0	75,0	75,0				75,0	75,0	75,0
PARNAIB_IV (56)	Gás	151,69	19,1	19,1	19,1				19,1	19,1	19,1				19,1	19,1	19,1
PARNAIBA_V (386)	Vapor	222,60	109,0	109,0	109,0				109,0	109,0	109,0				109,0	109,0	109,0
N.VENECIA2 (270)	Gás	286,88	41,2	35,5	20,6				41,2	35,5	20,6				41,2	35,5	20,6
P. ITAQUI (360)	Carvão	341,18															
GERAMAR1 (166)	Óleo	1197,78															
GERAMAR2 (166)	Óleo	1197,78															
TOTAL NORTE (3756)			1449,3	1444,7	1432,7	326,8	326,8	326,8	1776,1	1771,5	1759,5	0,0	0,0	0,0	1776,1	1771,5	1759,5

O conteúdo desta publicação foi produzido pelo ONS com base em dados e informações de conhecimento público. É de responsabilidade exclusiva dos agentes e demais interessados a obtenção de outros dados e informações, a realização de análises, estudos e avaliações para fins de tomada de decisões, definição de estratégias de atuação, assunção de compromissos e obrigações e quaisquer outras finalidades, em qualquer tempo e sob qualquer condição. É proibida a reprodução ou utilização total ou parcial do presente sem a identificação da fonte.