1. APRESENTAÇÃO

O mês de julho foi marcado pela distribuição irregular de precipitação nas bacias hidrográficas da Região Sul. Na primeira quinzena do mês, não houve precipitação nas bacias hidrográficas de interesse do SIN. A partir da segunda quinzena, houve precipitação nas bacias dos rios Jacuí e Uruguai, embora com totais inferiores à média.

Na semana de 19/07 a 25/07 não houve precipitação nas bacias hidrográficas de interesse do SIN.

Na semana de 26/07 a 01/08/2025 deve ocorrer precipitação nas bacias hidrográficas da Região Sul e em pontos isolados da bacia do rio Tietê e dos trechos boliviano e peruano do Madeira, sendo que os maiores totais de precipitação são esperados nas bacias dos rios Jacuí e Uruguai.

Os valores médios semanais do Custo Marginal de Operação – CMO dos subsistemas do SIN sofreram as seguintes alterações em relação à semana anterior:

- SE/CO: de R$ 256,30/MWh para R$ 315,08/MWh
- Sul: de R$ 256,30/MWh para R$ 315,08/MWh
- Nordeste: de R$ 256,30/MWh para R$ 315,08/MWh
- Norte: de R$ 256,30/MWh para R$ 315,08/MWh

Desde o dia 01/01/2020, o despacho por ordem de mérito é indicado diariamente pelos resultados do modelo DESSEM. Assim, o despacho por ordem de mérito semanal, conforme publicado nesse documento, tem caráter apenas informativo. Da mesma forma, desde o dia 01/01/2021, a formação de preço deixou o formato semanal/patamar de carga e passou a ser horário, de acordo também com os resultados do modelo DESSEM.

ATENÇÃO: O tópico "Informações para a construção da Função de Custo Futuro", presente nesse documento em toda Revisão 0, será descontinuado a partir do PMO Setembro/2025. Todo seu conteúdo estará contemplado na Notas Técnicas - Medio Prazo.

2. NOTÍCIAS

Nos dias 28 e 29 de agosto será realizada a reunião de elaboração do PMO de Setembro de 2025, com transmissão ao vivo através do site do ONS.

3. INFORMAÇÕES PARA A CONSTRUÇÃO DA FUNÇÃO DE CUSTO FUTURO

A atualização de dados para os estudos energéticos de médio prazo é realizada mensalmente quando da elaboração do PMO, tendo por base as informações fornecidas pela ANEEL, MME, EPE, CCEE e Agentes, além de diversas áreas do ONS.

O conteúdo desta publicação foi produzido pelo ONS com base em dados e informações de conhecimento público. É de responsabilidade exclusiva dos agentes e demais interessados a obtenção de outros dados e informações, a realização de análises, estudos e avaliações para fins de tomada de decisões, definição de estratégias de atuação, assunção de compromissos e obrigações e quaisquer outras finalidades, em qualquer tempo e sob qualquer condição. É proibida a reprodução ou utilização total ou parcial do presente sem a identificação da fonte.

3.1. Informações Estruturais

- **Armazenamentos Iniciais**

Os armazenamentos iniciais equivalentes por subsistema, considerados no modelo NEWAVE, são obtidos a partir dos armazenamentos iniciais dos reservatórios individualizados, utilizados no modelo DECOMP e informados pelos Agentes de Geração para a elaboração do PMO de agosto/2025.

Estes valores, apresentados na Figura 1, a seguir, determinam a condição inicial de energia armazenada nos subsistemas do SIN sendo utilizada como recurso energético quando da definição da política de operação do SIN.

Figura 1 – Energia armazenada inicial em julho/25 e agosto/25

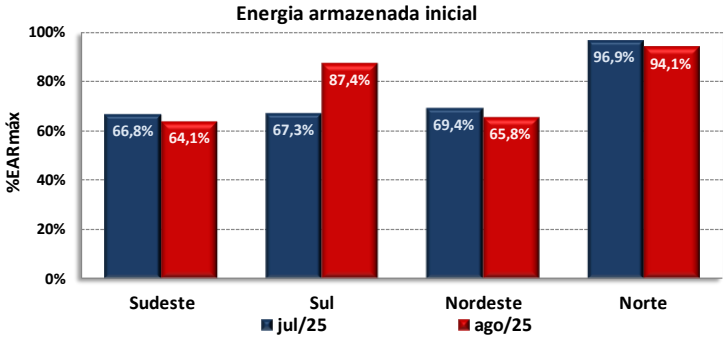

- **Tendência Hidrológica**

Na Tabela 1 a seguir, são apresentadas as tendências hidrológicas calculadas pelo NEWAVE para o PMO de Agosto/2025, comparadas com o PMO de Julho/2025.

Tabela 1 – Tendência hidrológica para o PMO de Agosto/2025 – NEWAVE [%MLT]

	PMO Julho/2025				PMO Agosto/2025			
MÊS	SE/CO	S	NE	N	SE/CO	S	NE	N
jan/25	97	70	102	108				
fev/25	83	85	87	113	82	85	87	111
mar/25	61	53	25	99	60	53	25	98
abr/25	83	65	30	84	81	65	30	83
mai/25	83	40	46	70	81	40	46	69
jun/25	82	166	41	63	81	174	41	62
jul/25					77	115	47	66

* ≥100% MLT < 100% MLT

No NEWAVE, os cenários de ENA são estimados por um modelo autorregressivo de geração estocástica mensal (GEVAZP "energia") interno ao modelo, cuja ordem máxima está limitada em 6 meses.

Assim, as ENAs verificadas nos 6 meses anteriores constituem uma informação relevante, uma vez que caracterizam a tendência hidrológica da árvore de cenários que será utilizada para a construção da Função de Custo Futuro, com influência direta nos resultados do PMO.

O conteúdo desta publicação foi produzido pelo ONS com base em dados e informações de conhecimento público. É de responsabilidade exclusiva dos agentes e demais interessados a obtenção de outros dados e informações, a realização de análises, estudos e avaliações para fins de tomada de decisões, definição de estratégias de atuação, assunção de compromissos e obrigações e quaisquer outras finalidades, em qualquer tempo e sob qualquer condição. É proibida a reprodução ou utilização total ou parcial do presente sem a identificação da fonte.

- **Destaques da Expansão da Oferta 2025/2029**

As principais alterações no cronograma, conforme reunião do DPME de 17/07/2025, estão apresentadas nas Figura 2, Figura 3 e Figura 4, a seguir, apresentam a evolução da oferta hidroelétrica, termoelétrica e da disponibilidade das usinas não simuladas individualmente, respectivamente, em comparação ao PMO de Julho/2025.

Figura 2 - Evolução da potência instalada das UHEs

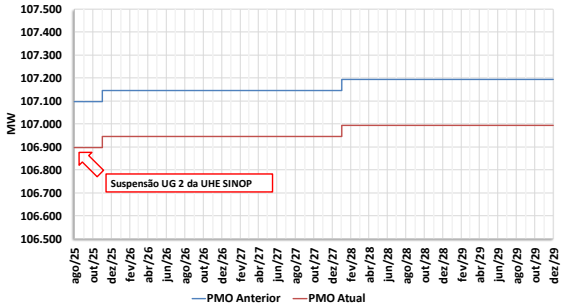

Figura 3 - Evolução da potência instalada das UTEs

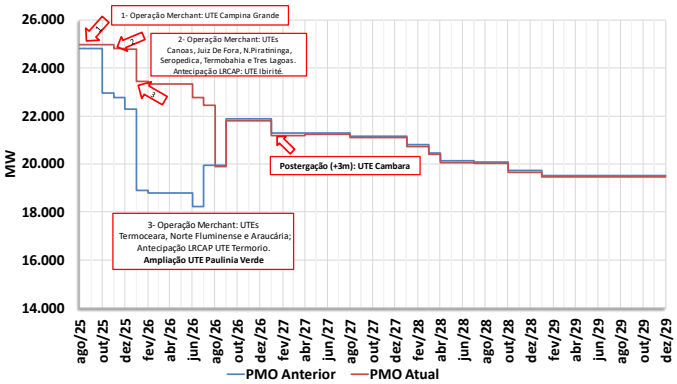

Figura 4 - Evolução da disponibilidade das usinas não simuladas

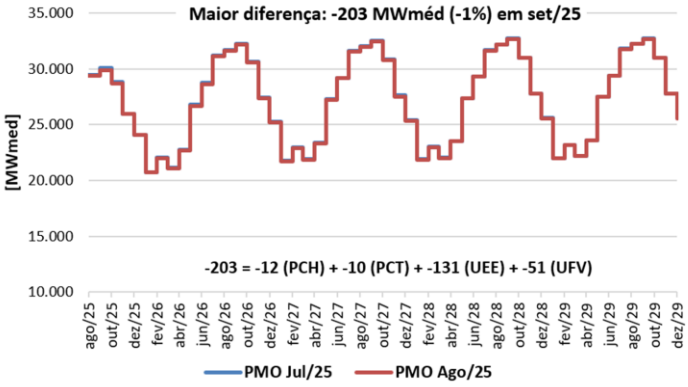

O conteúdo desta publicação foi produzido pelo ONS com base em dados e informações de conhecimento público. É de responsabilidade exclusiva dos agentes e demais interessados a obtenção de outros dados e informações, a realização de análises, estudos e avaliações para fins de tomada de decisões, definição de estratégias de atuação, assunção de compromissos e obrigações e quaisquer outras finalidades, em qualquer tempo e sob qualquer condição. É proibida a reprodução ou utilização total ou parcial do presente sem a identificação da fonte.

3.2. Modelagem das Restrições de Defluência do rio São Francisco

A partir do PMO de Janeiro de 2023, foi implementada a metodologia de estabelecimento da Curva de Representação dos Condicionantes Hidráulicos (CRCH) para a bacia do rio São Francisco, curva atualizada anualmente, passível de revisões quadrimestrais, e excepcionalmente mensais, que limita a defluência máxima mensal da UHE Xingó nos modelos energéticos, diante da condição de operação do reservatório de Sobradinho na faixa de normal de operação, quando seu volume útil se encontra acima de 60%, bem como a curva definida para o ano de 2024, com divulgação através de FSARH. Tal aprimoramento representará os condicionantes e diretrizes hidráulicas da bacia do rio São Francisco (resolução ANA 2.081/2017). Destaca-se que a partir do PMO de Janeiro de 2025, a modelagem do rio São Francisco segue com a mesma curva e premissas consideradas para o ano de 2024. A Tabela 2 a seguir traz os valores das defluências considerados nesse PMO.

Tabela 2 – Defluência das UHEs Três Marias, Sobradinho, Itaparica, Comp. P. Afonso/Moxotó e Xingó

PMO Atual						
Vazão [m³/s]	Dois primeiros meses				A partir de	
	Ago/25		Set/25		Out/25	
	Qmin	Qmáx	Qmin	Qmáx	Qmin	Qmáx
Três Marias	**150**	-	**150**	-	**150**	-
Sobradinho	**800**	-	**800**	-	**800**	-
Luiz Gonzaga (Itaparica)	**800**	-	**800**	-	**800**	-
Complexo P. Afonso / Moxotó	**800**	-	**800**	-	**800**	-
Xingó	**800**	**1000**	**800**	**1000**	**800**	-

3.3. Representação da Defluência das UHEs do Paranapanema

As restrições de defluências das UHEs do Paranapanema são definidas conforme Resolução ANA nº132/2024 de acordo com a figura abaixo.

Figura 5 - Restrições de defluências das UHEs do Paranapanema

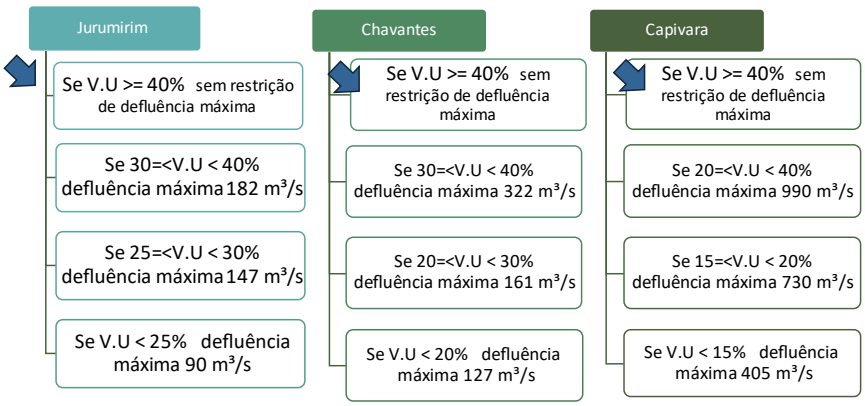

De acordo com a previsão do % do V.U da UHEs é estabelecida a faixa na qual a usina se encontra. De acordo com a simulação hidráulica feita para esse PMO, a expectativa é de que todas as UHEs estarão na faixa de operação normal. Portanto, não há restrição de defluência máxima para as UHEs.

O conteúdo desta publicação foi produzido pelo ONS com base em dados e informações de conhecimento público. É de responsabilidade exclusiva dos agentes e demais interessados a obtenção de outros dados e informações, a realização de análises, estudos e avaliações para fins de tomada de decisões, definição de estratégias de atuação, assunção de compromissos e obrigações e quaisquer outras finalidades, em qualquer tempo e sob qualquer condição. É proibida a reprodução ou utilização total ou parcial do presente sem a identificação da fonte.

3.4. Representação da Defluência das UHEs do rio Grande

A partir do PMO de Dezembro de 2024 as restrições de defluências das UHEs do rio Grande foram definidas conforme Resolução ANA nº193/2024 de acordo com a figura abaixo.

Figura 6 - Restrições de defluências das UHEs do Grande

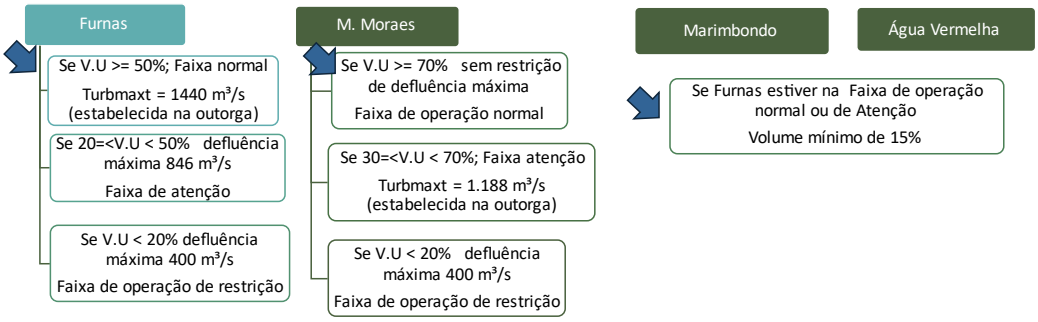

De acordo com a previsão do % do V.U das UHEs de Furnas e M. Moraes são estabelecidas as faixas nas quais as usinas se encontram. Para as UHEs Marimbondo e Água Vermelha, caso Furnas esteja na Faixa de operação normal ou de atenção, deverá ser aplicada uma restrição de volume mínimo de 15% para as hidrelétricas. Dado a expectativa de que todas as UHEs estarão na faixa de operação normal, não há restrição de defluência máxima para elas.

Para as UHEs Marimbondo e Água Vermelha foram emitidas a FSARH 7036/2024 e 7038/2024 representando a restrição de volume mínimo a serem utilizadas nos dois primeiros meses.

3.5. Representação da Defluência das UHEs do rio Paranaíba

A partir do PMO de dezembro de 2024 as restrições de defluências das UHEs do rio Paranaíba foram definidas conforme Resolução ANA nº194/2024 de acordo com a figura abaixo.

Figura 7 - Restrições de defluências das UHEs do Paranaíba

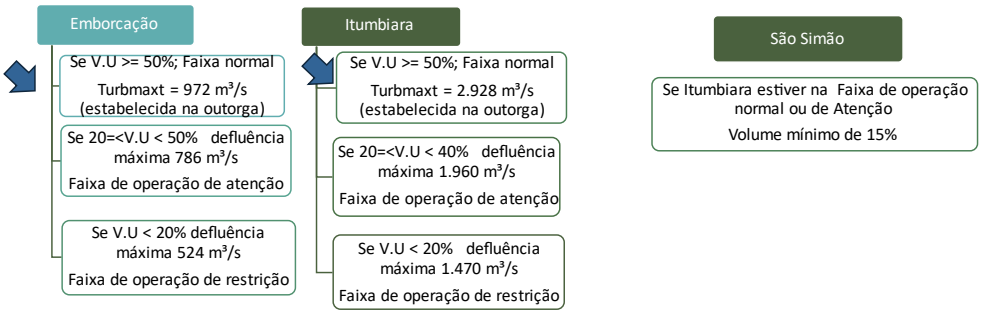

De acordo com a previsão do % do V.U das UHEs Emborcação e Itumbiara são estabelecidas as faixas nas quais as usinas se encontram. Para a UHE São Simão, caso Itumbiara esteja na Faixa de operação normal ou de atenção, deverá ser aplicada uma restrição de volume mínimo de 15% para a hidrelétrica. Dado a expectativa de que todas as UHEs estarão na faixa de operação normal, não há restrição de defluência máxima para elas. Para a UHE São Simão foi emitida a FSARH 7040/2024 representando a restrição de volume mínimo.

O conteúdo desta publicação foi produzido pelo ONS com base em dados e informações de conhecimento público. É de responsabilidade exclusiva dos agentes e demais interessados a obtenção de outros dados e informações, a realização de análises, estudos e avaliações para fins de tomada de decisões, definição de estratégias de atuação, assunção de compromissos e obrigações e quaisquer outras finalidades, em qualquer tempo e sob qualquer condição. É proibida a reprodução ou utilização total ou parcial do presente sem a identificação da fonte.

3.6. Restrição de escoamento das UHEs do Rio Madeira (UHE Santo Antônio e UHE Jirau)

A geração máxima da UHE Santo Antônio e UHE Jirau (Ger. MAD) é dada pela capacidade das usinas, da disponibilidade dos polos do Elo CC Madeira e back-to-back.

Assim, na modelagem energética, sem representação da rede de transmissão, esta restrição pode ser representada como:

- **Ger. MAD ≤ 6.300 + 700 + 417,6 (≤ 7.417,6 MW).**

Onde destaca-se que:

- 6.300 MW representa a capacidade em rede completa do Elo CC do Madeira;
- A capacidade do back-to-back é 800 MW, porém existem restrições na rede de 230 kV da região ACRO que não podem ser representadas no DECOMP. Para valores acima de 700 MW no back-to-back essas restrições limitariam a capacidade de exportação via rede de 230 kV do ACRO e limitariam a geração das usinas deste sistema, notadamente UHE Samuel, Rondon II e Santo Antonio. Adicionalmente, para rede completa, o valor de 700 MW no fluxo do back-to-back é suficiente para escoar a geração completa do complexo do Madeira;
- 417,6 MW representa a geração disponível das unidades geradoras da UHE Santo Antônio conectadas no 230 kV.

Os valores de restrição adotados neste PMO constam na Tabela 4 a seguir:

Tabela 3 - Modelagem da restrição de escoamento do rio madeira associada às UHEs Santo Antônio e Jirau via geração hidráulica máxima em comparação com o PMO anterior

Restrição Geração [MW]			
UHEs	**Cronograma**	PMO jul/2025	**PMO ago/2025**
Santo Antônio e Jirau	1º e 2º mês	7.340,40 / 7.412,81 (jul e ago/25)	**7.327,79 / 7.403,81 (ago e set/25)**

(*) Representação conforme Nota Técnica de Limites de Curto Prazo, compatibilizada com o DECOMP

3.7. Representação da antecipação do 1º Leilão de Reserva de Capacidade

No PMO de Agosto de 2025 foi considerada a antecipação de algumas usinas do 1º Leilão de Reserva de Capacidade de 2021. As informações consideradas na modelagem estão detalhadas na tabela abaixo.

Tabela 4 – Modelagem antecipação 1º LRCAP

Usinas	Potência (MW)	Subsistema	Termo Aditivo ao CRCAP	IP (%)	TEIF(%)	Vigência LRCAP	Vigência Contrato Mechant
Parnaíba IV	56,28	Norte	CRCAP 4/21	4,3	5,5	A partir de out/25	ago/25 e set/25
Geramar I	165,87	Norte	CRCAP 7/21	2,7	1,3	A partir de out/25	ago/25 e set/25
Geramar II	165,87	Norte	CRCAP 8/21	2,7	1,3	A partir de out/25	ago/25 e set/25
VIANA	174,6	Sudeste	CRCAP 10/21	0,6	2,42	A partir de ago/25	-
Ibirité	235	Sudeste	CRCAP 12/21	5,8	4,7	A partir de ago/25	-
Termorio	989,2	Sudeste	CRCAP 13/21	5,2	6	A partir de ago/25	-

(*) UTEs não antecipadas: Potiguar, Potiguar III, Global I e Global II suspensão de OPC
W. Arjona: termo aditivo não assinado

O conteúdo desta publicação foi produzido pelo ONS com base em dados e informações de conhecimento público. É de responsabilidade exclusiva dos agentes e demais interessados a obtenção de outros dados e informações, a realização de análises, estudos e avaliações para fins de tomada de decisões, definição de estratégias de atuação, assunção de compromissos e obrigações e quaisquer outras finalidades, em qualquer tempo e sob qualquer condição. É proibida a reprodução ou utilização total ou parcial do presente sem a identificação da fonte.

3.8. Despachos de contratos merchant considerados no PMO

No PMO de Agosto de 2025 foram considerados os despachos de operação merchant das UTEs citadas na tabela abaixo assim como as informações que serão utilizadas na modelagem.

Tabela 5 – Contratos Merchant PMO Ago/25

Usinas	Potência (MW)	Despacho	CVU_SCF(R$) (mai/26 até fim vigência)	CVU_CF(R$) (Ago/25 até abr/26)	Vigência Início	Vigência Fim	Vigência Contrato Anterior
Termobahia	185,9	2.144/2025	686,9	1120,67	17/07/2025	16/07/2026	25/09/2025
Juiz de Fora	87,05	1.974/2025	1160,64	1312,72	02/07/2025	01/07/2026	12/09/2025
Ibirité	235	1.976/2025	808,01	843,13	02/07/2025	01/07/2026	12/09/2025
Canoas	248,57	1.972/2025	1230,97	1359,32	02/07/2025	01/07/2026	12/09/2025
Nova Piratininga	386,38	1.973/2025	1381,13	1586,02	01/07/2025	30/06/2026	12/09/2025
Três Lagoas	350	2.043/2025	957,31	1060,2	09/07/2025	08/07/2026	23/09/2025
Seropédica	360	1.983/2025	1209,84	1303,31	01/07/2025	30/06/2026	12/09/2025
Araucária	484,15	1.985/2025	1044,52	1181,5	02/07/2025	01/07/2026	05/11/2025
Norte Fluminense	826,78	1.977/2025	1086,14	1225,21	02/07/2025	01/07/2026	08/12/2025
Termorio	989,2	1.982/2025	906,79	939,08	02/07/2025	01/07/2026	31/12/2025
Termoceará	223	2.154/2025	1874,98	2181,31	18/07/2025	17/07/2026	31/12/2025
Campina Grande	169,08	2.050/2025	1326,07	2296,46	08/07/2025	07/07/2026	-

3.9. Geração UHE Cachoeira Caldeirão e UHE Ferreira Gomes (G CC+FG)

O limite para a soma de geração das UHE Cachoeira Caldeirão e UHE Ferreira Gomes é definido pelo desempenho dinâmico do sistema Macapá. Este limite é necessário em decorrência da perturbação do dia 18/02/2025, quando a abertura intempestiva de um dos circuitos da LT 230 kV Macapá – Laranjal ocasionou oscilações sustentadas na área de Macapá. Este limite deve ser válido até que as causas sejam identificadas e solucionadas em conjunto com Agentes envolvidos.

Tabela 6 - Limites para geração UHE Cachoeira Caldeirão e UHE Ferreira Gomes

Restrição Geração [MW]			
UHEs	**Cronograma**	PMO jul/2025	**PMO ago/2025**
Cachoeira Caldeirão e Ferreira Gomes	1º e 2º mês	400,00 (jul e ago/25)	**400,00 (ago e set/25)**

Os limites constam no relatório RT-ONS DPL 0013/2025 – Volume 20.

O conteúdo desta publicação foi produzido pelo ONS com base em dados e informações de conhecimento público. É de responsabilidade exclusiva dos agentes e demais interessados a obtenção de outros dados e informações, a realização de análises, estudos e avaliações para fins de tomada de decisões, definição de estratégias de atuação, assunção de compromissos e obrigações e quaisquer outras finalidades, em qualquer tempo e sob qualquer condição. É proibida a reprodução ou utilização total ou parcial do presente sem a identificação da fonte.

3.10. Demais Atualizações

Adicionalmente, neste PMO ocorreram os seguintes destaques:

- Horizonte de estudo: agosto de 2025 a dezembro de 2029;
- Cronograma de Obras – Reunião de Monitoramento da Expansão da Oferta de 18/julho/2025 com destaque para postergação da UTE Cambara e ampliação da UTE Paulinia Verde;
- CVUs das UTEs vendedoras em leilão;
- CVU das UTEs merchants com atualização pela CCEE e aplicação da REN ANEEL nº 1.093/2024;
- Suspensão da operação comercial da UG 2 da UHE Sinop conforme Despacho ANEEL nº 2.027/2025;
- Modelagem da antecipação do suprimento dos contratos de potência de reserva de capacidade referente ao 1° Leilão para Contratação de Reserva de Capacidade, realizado em 21/12/2021, das UTEs Parnaíba IV, Geramar I, Geramar II, Viana, Ibirité e Termorio, conforme os Termos Aditivos disponíveis na CCEE;
- Alteração de titularidade das UTEs Cristiano Rocha, Manauara, Ponta Negra para J&F Investimentos conforme Despacho ANEEL nº 1.602/2025;
- Atualização das diretrizes operativas para as bacias do rio Grande, rio Paranaíba, rio Paranapanema, rio São Francisco e rio Tocantins;
- Alteração de restrição operativa para as UHEs Furnas, Emborcação, Itumbiara, Três Marias, Xingó, Sobradinho e Passo Real;
- Compatibilização da disponibilidade e inflexibilidade das usinas termoelétricas para os dois primeiros meses de acordo com informação da programação mensal;
- Compatibilização dos valores dos dois primeiros meses da geração hidráulica mínima das UHEs Itaipu e Tucuruí de acordo com os utilizados na programação mensal;
- Compatibilização dos estágios de deplecionamento das UHEs do Paraíba do Sul de acordo com informação da programação mensal;
- Limites de Intercâmbio segundo Relatório Mensal de Limites de Intercâmbio RT-ONS DPL 0298/2025;
- Consideração no primeiro mês das previsões obtidas com o modelo WEOL-SM como estimativa de geração das usinas eólicas não simuladas individualmente para os subsistemas Sul, Nordeste e Norte;
- Previsões de carga consolidada para os dois primeiros meses;
- Valores de geração prevista para as usinas térmicas GNL da Revisão 3 do PMO de julho/2025.

O conteúdo desta publicação foi produzido pelo ONS com base em dados e informações de conhecimento público. É de responsabilidade exclusiva dos agentes e demais interessados a obtenção de outros dados e informações, a realização de análises, estudos e avaliações para fins de tomada de decisões, definição de estratégias de atuação, assunção de compromissos e obrigações e quaisquer outras finalidades, em qualquer tempo e sob qualquer condição. É proibida a reprodução ou utilização total ou parcial do presente sem a identificação da fonte.

4. INFORMAÇÕES CONJUNTURAIS PARA ELABORAÇÃO DO PMO

4.1. Informações hidrometeorológicas

4.1.1. Condições antecedentes

O mês de julho foi marcado pela distribuição irregular de precipitação nas bacias hidrográficas da Região Sul. Na primeira quinzena do mês, a atuação de um sistema de alta pressão sobre as Regiões Sul, Sudeste e Centro-Oeste impediu o avanço de frentes frias pelo país, predominando a estiagem nas bacias hidrográficas de interesse do SIN. A partir da segunda quinzena, a rápida passagem de frentes frias pela Região Sul ocasionou precipitação nas bacias dos rios Jacuí e Uruguai, embora com totais inferiores à média. Com a configuração observada, o acumulado mensal de precipitação foi inferior à média histórica nas bacias hidrográficas de interesse do SIN (Figura 8).

Figura 8 - Mapa de anomalia da precipitação acumulada (mm) – Julho/2025

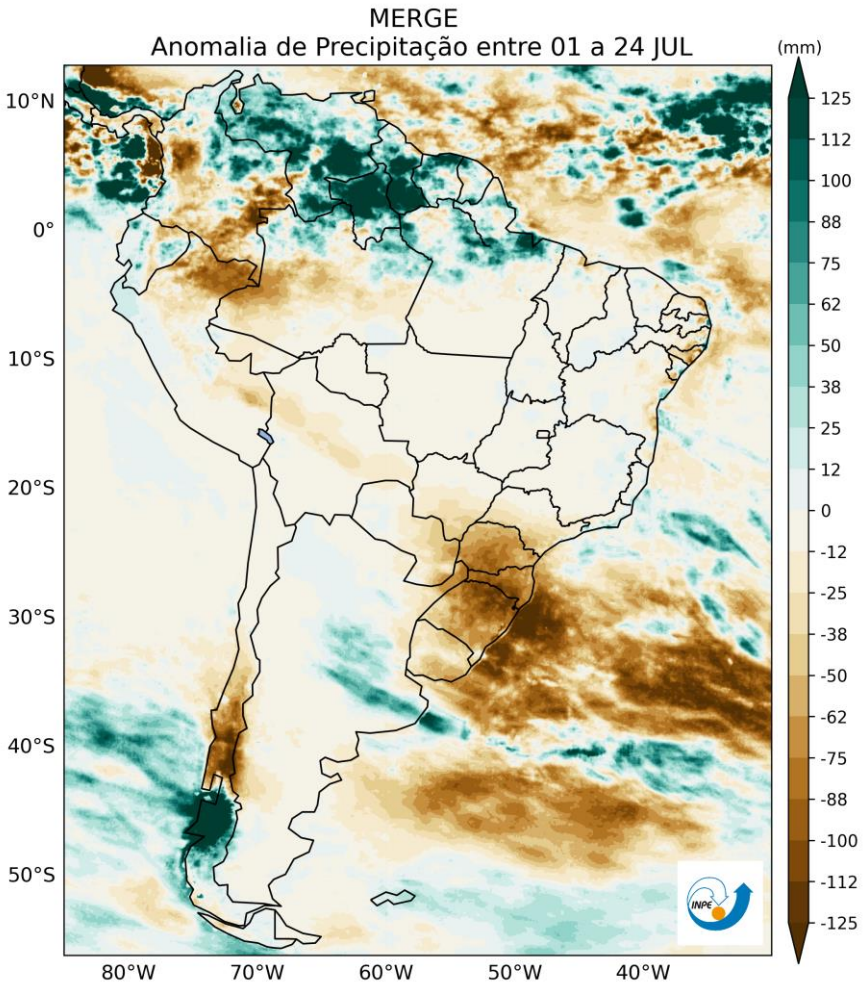

A condição de estiagem permaneceu na maior parte do país no decorrer da semana, desfavorecendo a ocorrência de precipitação nas bacias hidrográficas de interesse do SIN (Figura 9).

O conteúdo desta publicação foi produzido pelo ONS com base em dados e informações de conhecimento público. É de responsabilidade exclusiva dos agentes e demais interessados a obtenção de outros dados e informações, a realização de análises, estudos e avaliações para fins de tomada de decisões, definição de estratégias de atuação, assunção de compromissos e obrigações e quaisquer outras finalidades, em qualquer tempo e sob qualquer condição. É proibida a reprodução ou utilização total ou parcial do presente sem a identificação da fonte.

Figura 9 - Precipitação observada (mm) no período de 19 a 23/07/2025

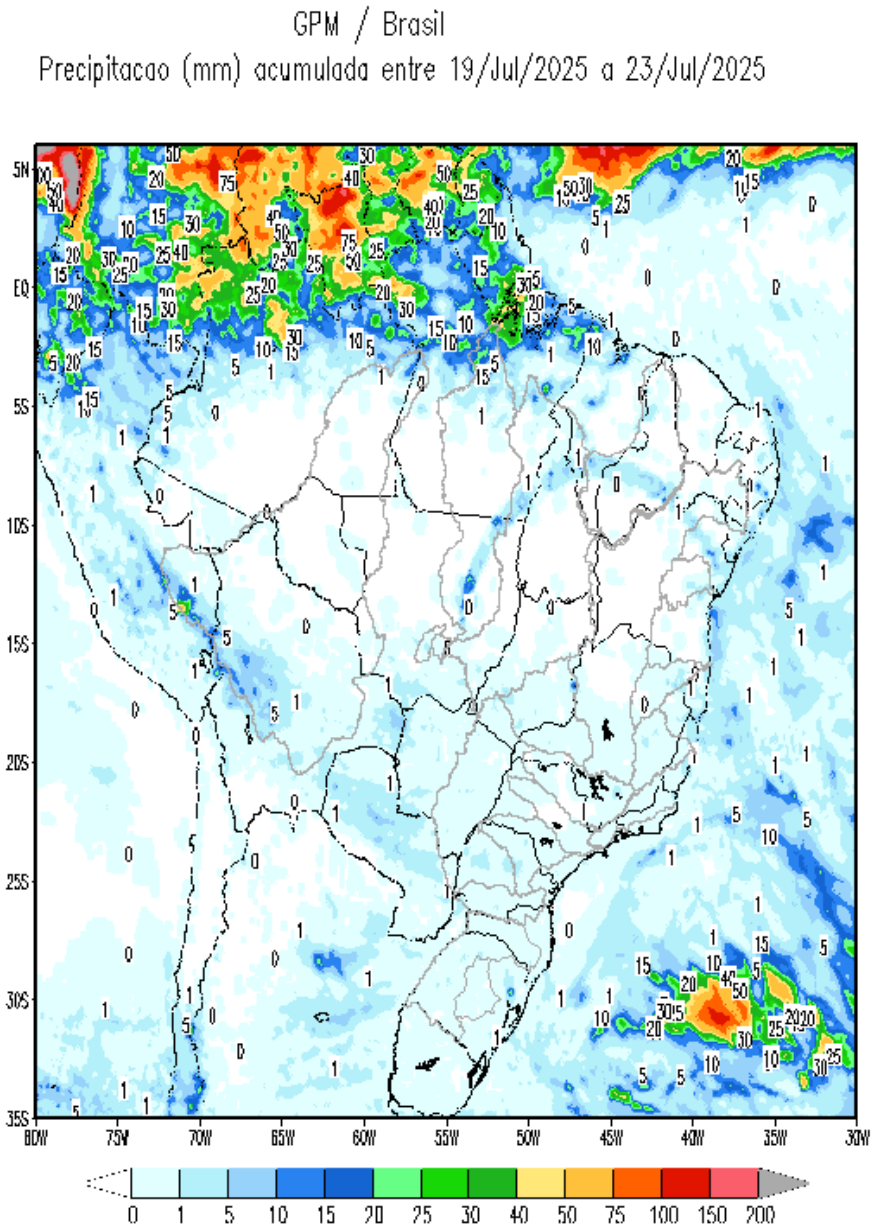

A Tabela 7 apresenta as energias naturais afluentes das semanas recentes. São apresentados os valores verificados na semana 12/07/2025 a 18/07/2025 e os estimados para fechamento da semana de 19/07/2025 a 25/07/2025.

Tabela 7 – Tendência hidrológica da ENA do PMO de Agosto/2025

PMO de Agosto/2025 - ENAs verificadas e estimadas				
Subsistema	12/07 a 18/07/2025		19/07 a 25/07/2025	
	MWmed	%MLT	MWmed	%MLT
SE/CO	19.995	78	17.847	70
S	8.315	76	5.748	52
NE	1.736	46	1.728	46
N	3.541	68	3.107	59

O conteúdo desta publicação foi produzido pelo ONS com base em dados e informações de conhecimento público. É de responsabilidade exclusiva dos agentes e demais interessados a obtenção de outros dados e informações, a realização de análises, estudos e avaliações para fins de tomada de decisões, definição de estratégias de atuação, assunção de compromissos e obrigações e quaisquer outras finalidades, em qualquer tempo e sob qualquer condição. É proibida a reprodução ou utilização total ou parcial do presente sem a identificação da fonte.

4.1.2. Climatologia para o trimestre agosto-setembro-outubro de 2025

Para o trimestre agosto-setembro-outubro (ASO) de 2025, o cenário mais provável é de precipitação entre normal e abaixo da média na Região Sul, e próximo da média nas demais bacias hidrográficas do SIN.

Climatologicamente, nesse trimestre os maiores totais de precipitação são observados no oeste da Região Norte e nas bacias hidrográficas da Região Sul (Figura 10).

Figura 10 - Climatologia de precipitação para o trimestre agosto-setembro-outubro

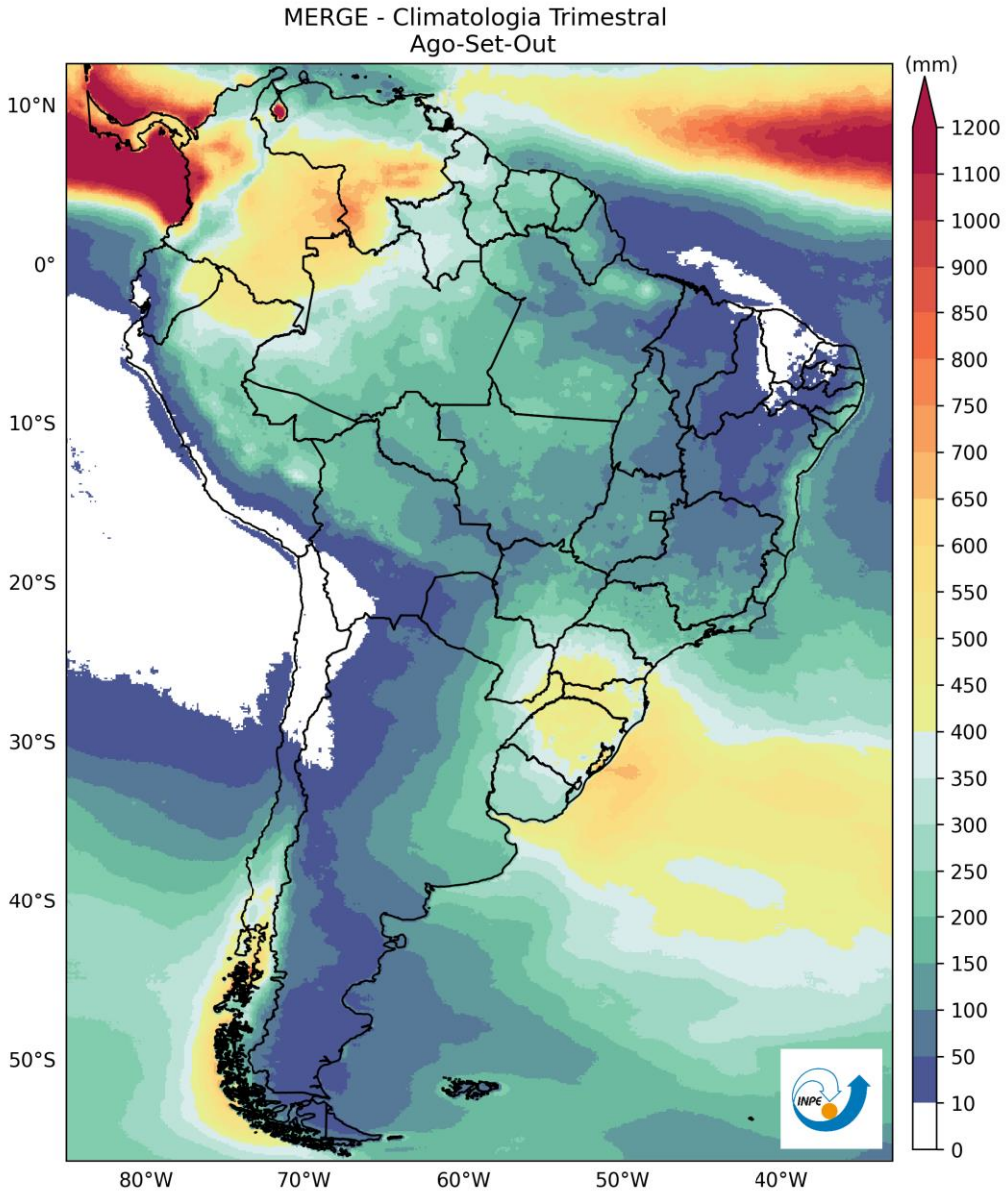

Fonte: Centro de Previsão de Tempo e Estudos Climáticos - CPTEC.

O conteúdo desta publicação foi produzido pelo ONS com base em dados e informações de conhecimento público. É de responsabilidade exclusiva dos agentes e demais interessados a obtenção de outros dados e informações, a realização de análises, estudos e avaliações para fins de tomada de decisões, definição de estratégias de atuação, assunção de compromissos e obrigações e quaisquer outras finalidades, em qualquer tempo e sob qualquer condição. É proibida a reprodução ou utilização total ou parcial do presente sem a identificação da fonte.

4.1.3. Previsão para a próxima semana

A atuação de áreas de instabilidade e a passagem de duas frentes frias pelas Regiões Sul e Sudeste ocasionam precipitação nas bacias hidrográficas da Região Sul e em pontos isolados da bacia do rio Tietê e dos trechos boliviano e peruano do Madeira, sendo que os maiores totais de precipitação são esperados nas bacias dos rios Jacuí e Uruguai (Figura 11).

Figura 11 - Precipitação acumulada prevista pelo modelo ECMWF - período de 26/07 a 01/08/2025

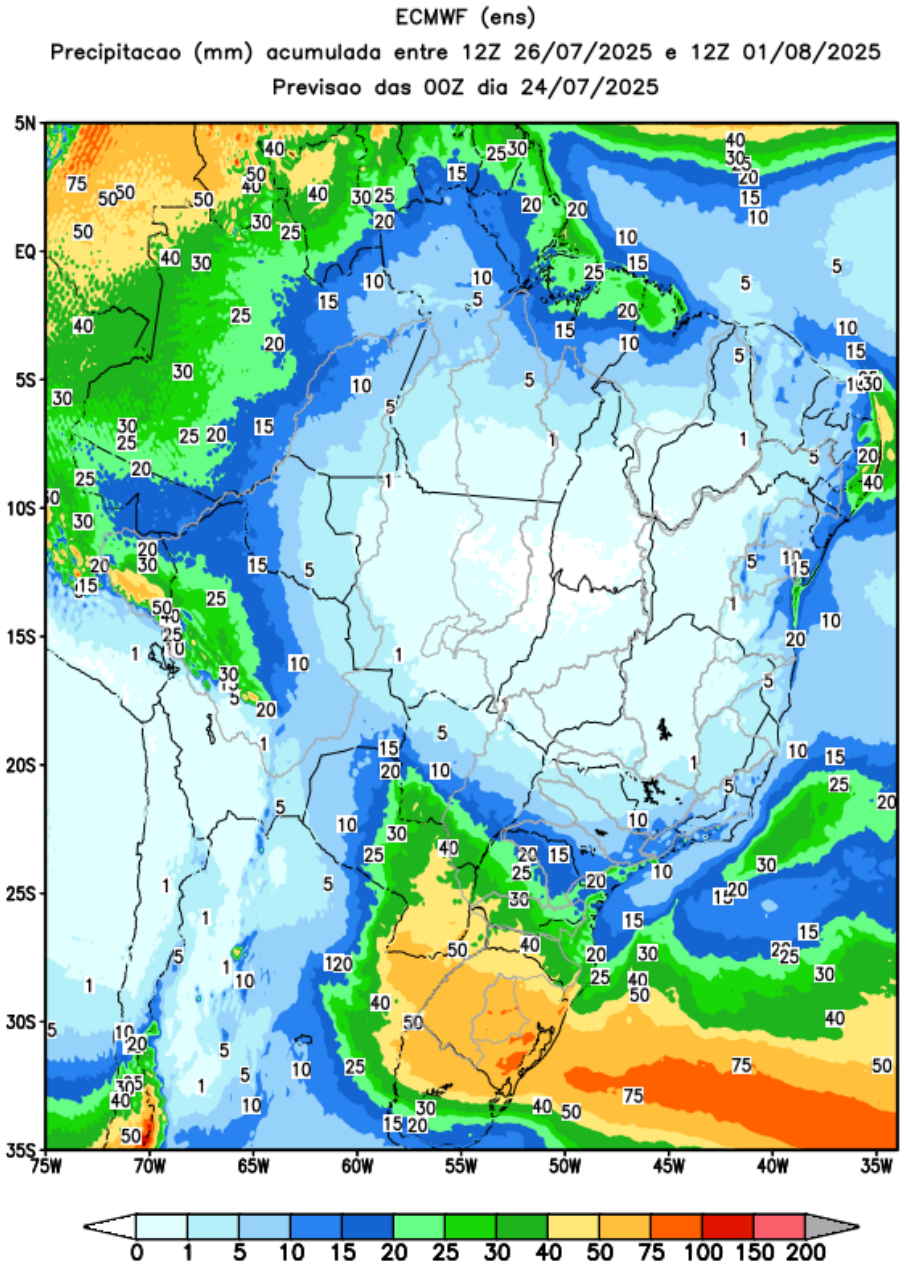

Em comparação com os valores estimados para a semana em curso, prevê-se para a próxima semana operativa ascensão nas afluências do subsistema Sul e recessão nas afluências dos subsistemas Sudeste/Centro-Oeste, Nordeste e Norte. A previsão mensal para agosto indica a ocorrência de afluências abaixo da média histórica para todos os subsistemas.

O conteúdo desta publicação foi produzido pelo ONS com base em dados e informações de conhecimento público. É de responsabilidade exclusiva dos agentes e demais interessados a obtenção de outros dados e informações, a realização de análises, estudos e avaliações para fins de tomada de decisões, definição de estratégias de atuação, assunção de compromissos e obrigações e quaisquer outras finalidades, em qualquer tempo e sob qualquer condição. É proibida a reprodução ou utilização total ou parcial do presente sem a identificação da fonte.

Tabela 8 – Previsão de ENAs do PMO de Agosto/2025

PMO de Agosto/2025 - ENAs previstas				
Subsistema	26/07 a 01/08/2025		Mês de agosto	
	MWmed	%MLT	MWmed	%MLT
SE/CO	17.017	68	15.530	76
S	8.293	77	8.163	82
NE	1.674	46	1.525	47
N	2.712	55	2.060	65

As figuras a seguir ilustram as ENAs semanais previstas no PMO de Agosto/2025.

Figura 12 - Energias Naturais Afluentes ao Subsistema Sudeste/Centro-Oeste do PMO de Agosto/2025

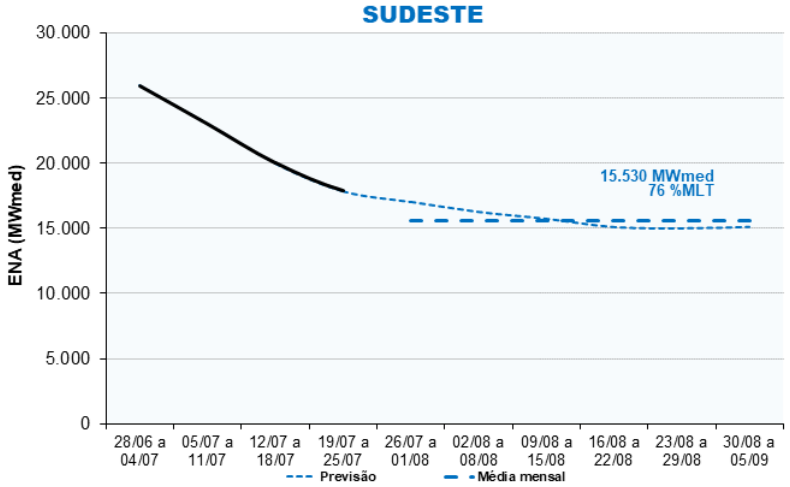

Figura 13 - Energias Naturais Afluentes ao Subsistema Sul do PMO de Agosto/2025

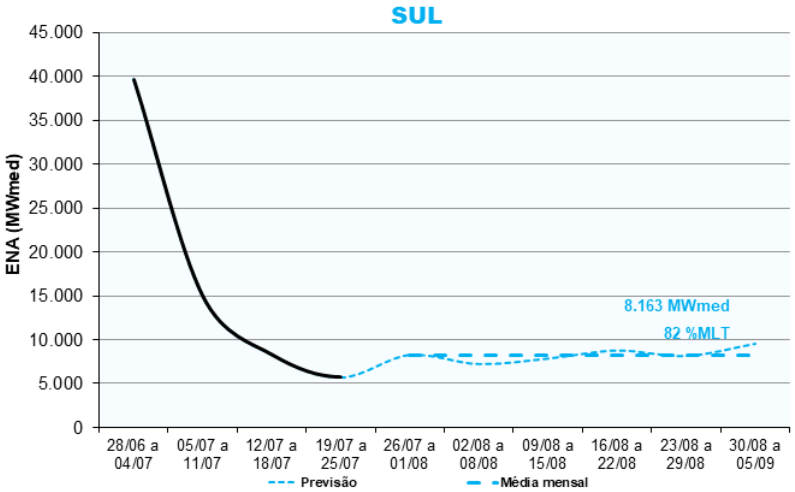

O conteúdo desta publicação foi produzido pelo ONS com base em dados e informações de conhecimento público. É de responsabilidade exclusiva dos agentes e demais interessados a obtenção de outros dados e informações, a realização de análises, estudos e avaliações para fins de tomada de decisões, definição de estratégias de atuação, assunção de compromissos e obrigações e quaisquer outras finalidades, em qualquer tempo e sob qualquer condição. É proibida a reprodução ou utilização total ou parcial do presente sem a identificação da fonte.

Figura 14 - Energias Naturais Afluentes ao Subsistema Nordeste do PMO de Agosto/2025

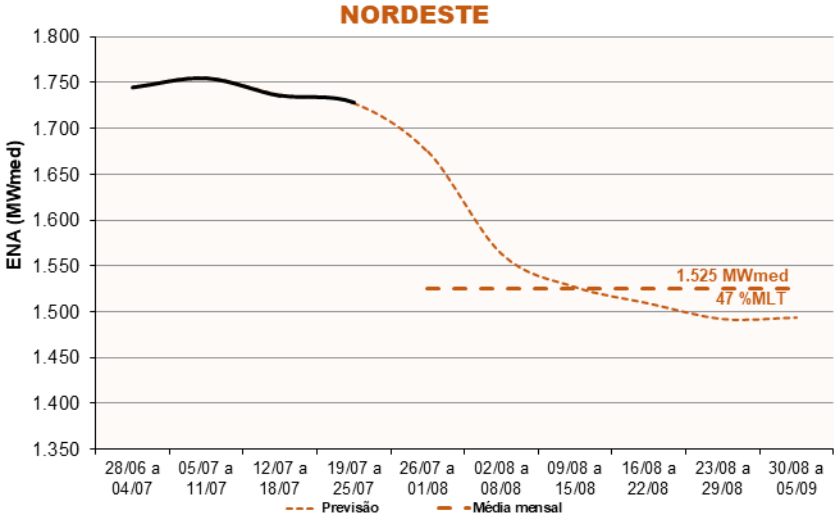

Figura 15 - Energias Naturais Afluentes ao Subsistema Norte do PMO de Agosto/2025

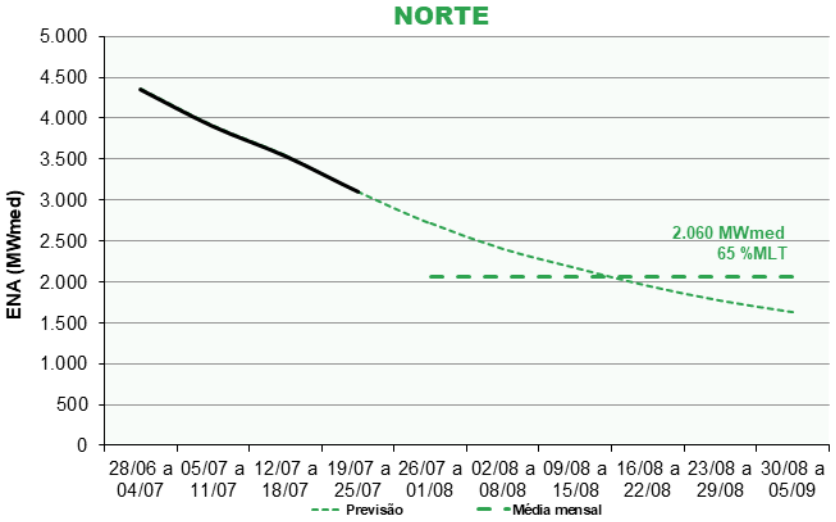

O conteúdo desta publicação foi produzido pelo ONS com base em dados e informações de conhecimento público. É de responsabilidade exclusiva dos agentes e demais interessados a obtenção de outros dados e informações, a realização de análises, estudos e avaliações para fins de tomada de decisões, definição de estratégias de atuação, assunção de compromissos e obrigações e quaisquer outras finalidades, em qualquer tempo e sob qualquer condição. É proibida a reprodução ou utilização total ou parcial do presente sem a identificação da fonte.

4.1.4. Cenários de ENAs para o PMO de Agosto/2025

As figuras a seguir apresentam as características dos cenários de energias naturais afluentes gerados no PMO de Agosto/2025, para acoplamento com a FCF do mês de setembro/2025. São mostradas, para os quatro subsistemas, as amplitudes e as Funções de Distribuição Acumulada dos cenários de ENA.

Figura 16 - Amplitude dos Cenários de ENA para o Subsistema Sudeste/Centro-Oeste, em %MLT, para o PMO de Agosto/2025

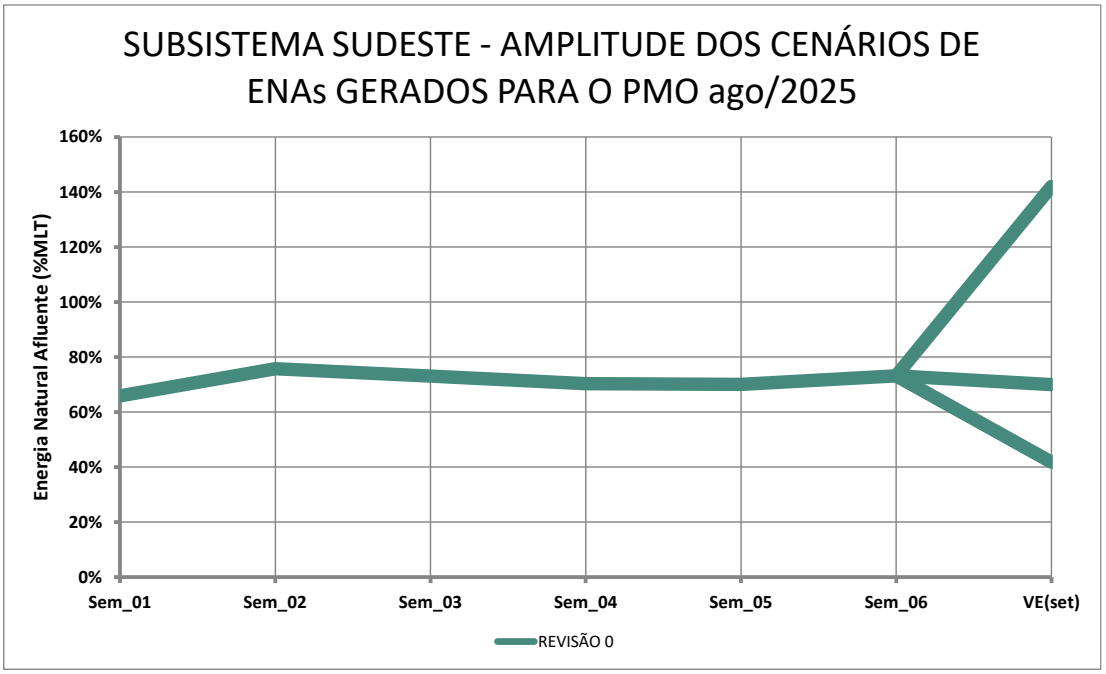

Figura 17 - Função de Distribuição Acumulada dos Cenários para o Subsistema Sudeste/Centro-Oeste para o PMO de agosto/2025

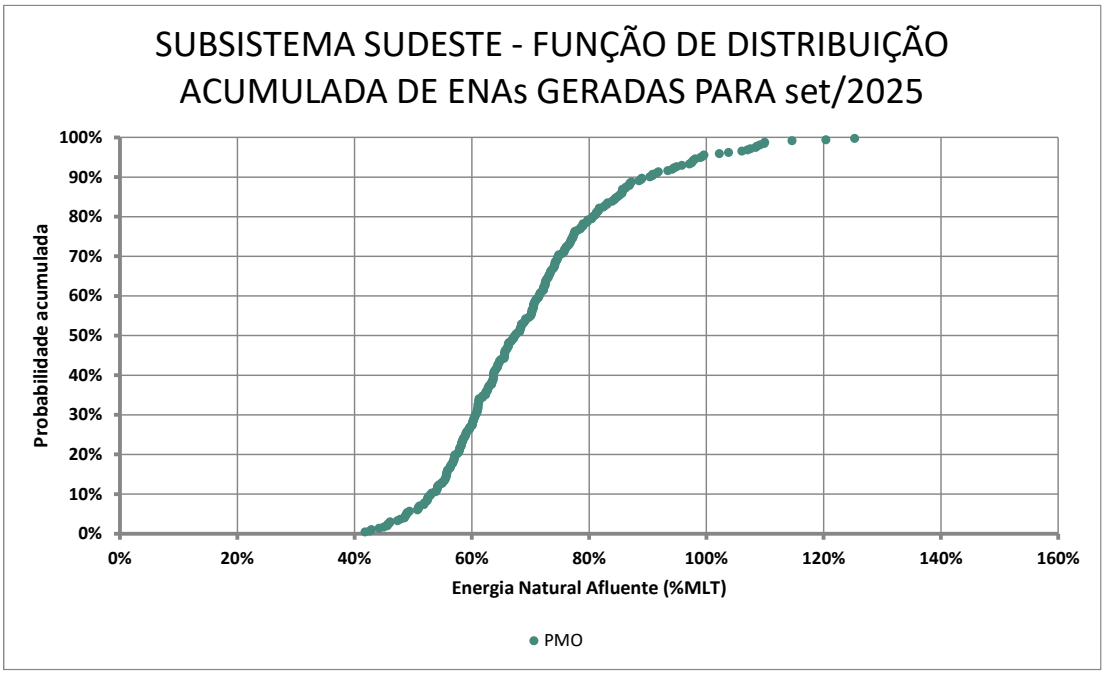

O conteúdo desta publicação foi produzido pelo ONS com base em dados e informações de conhecimento público. É de responsabilidade exclusiva dos agentes e demais interessados a obtenção de outros dados e informações, a realização de análises, estudos e avaliações para fins de tomada de decisões, definição de estratégias de atuação, assunção de compromissos e obrigações e quaisquer outras finalidades, em qualquer tempo e sob qualquer condição. É proibida a reprodução ou utilização total ou parcial do presente sem a identificação da fonte.

Figura 18 - Amplitude dos Cenários de ENA para o Subsistema Sul, em %MLT, para o PMO de Agosto/2025

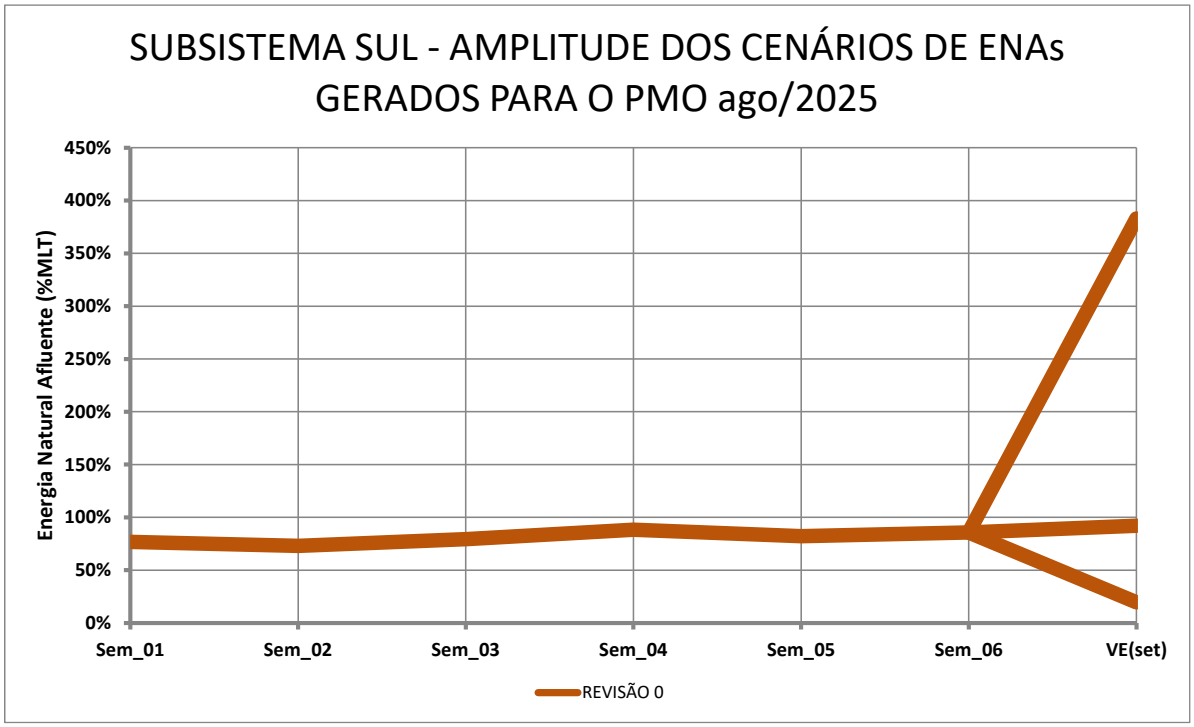

Figura 19 - Função de Distribuição Acumulada dos Cenários para o Subsistema Sul para o PMO de Agosto/2025

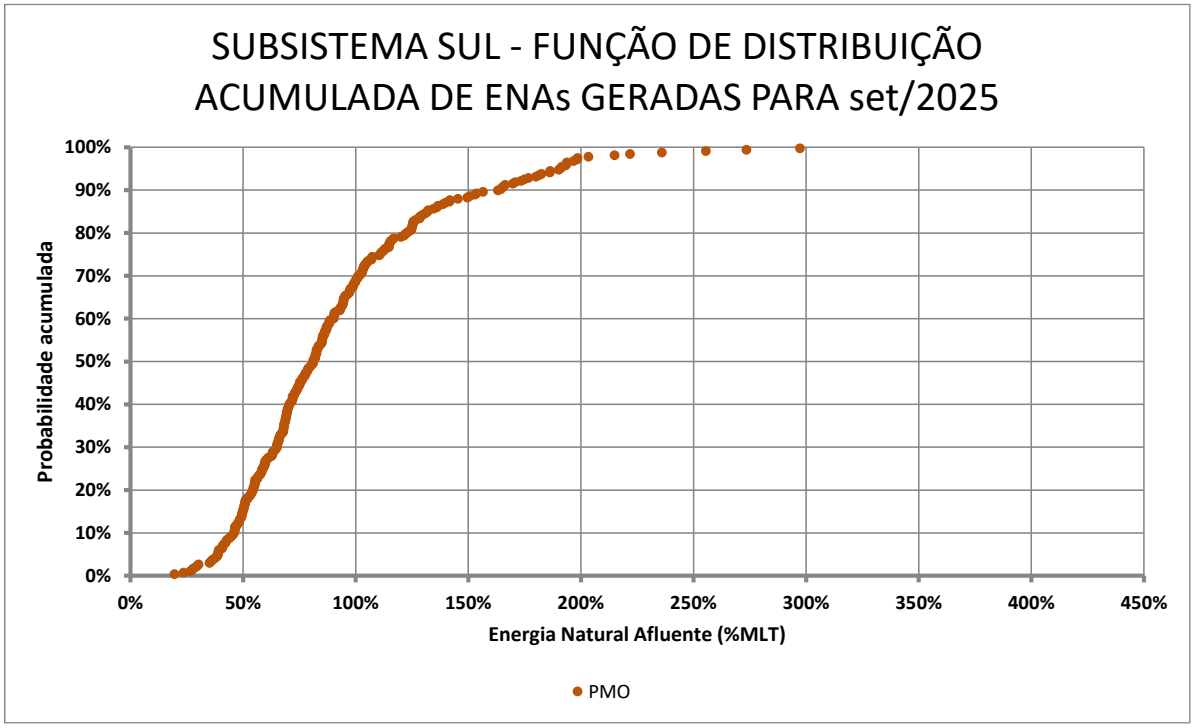

O conteúdo desta publicação foi produzido pelo ONS com base em dados e informações de conhecimento público. É de responsabilidade exclusiva dos agentes e demais interessados a obtenção de outros dados e informações, a realização de análises, estudos e avaliações para fins de tomada de decisões, definição de estratégias de atuação, assunção de compromissos e obrigações e quaisquer outras finalidades, em qualquer tempo e sob qualquer condição. É proibida a reprodução ou utilização total ou parcial do presente sem a identificação da fonte.

Figura 20 - Amplitude dos Cenários de ENA para o Subsistema Nordeste em %MLT, para o PMO de Agosto/2025

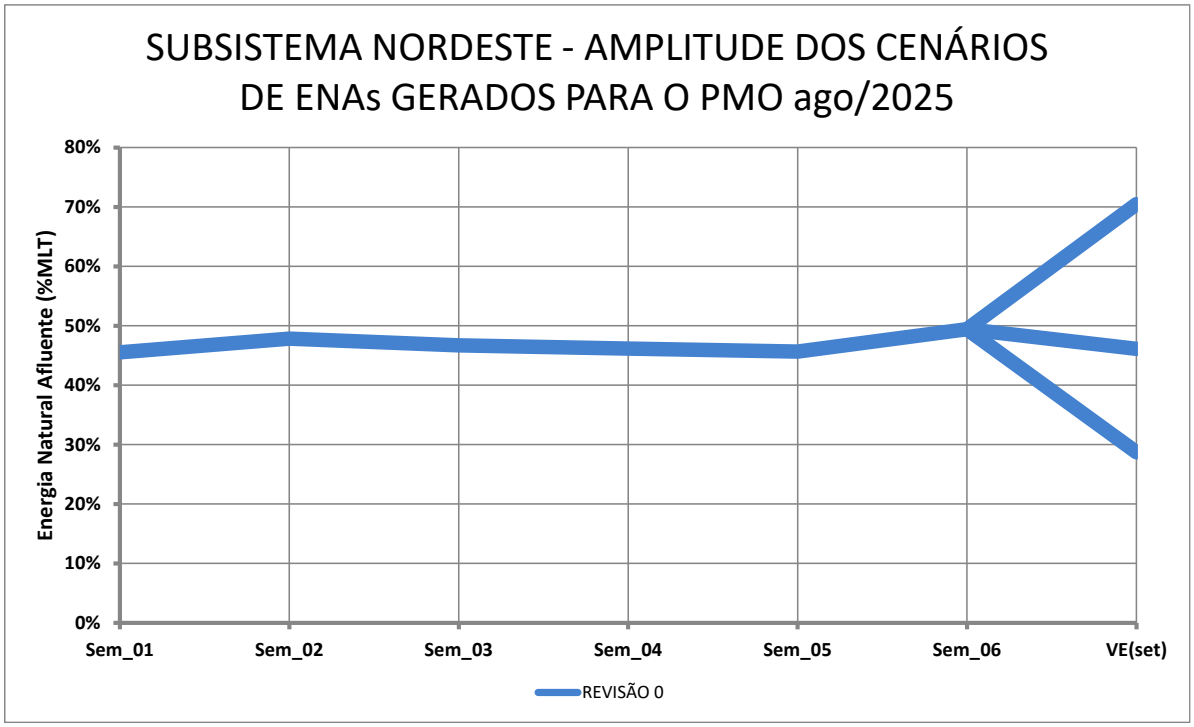

Figura 21 - Função de Distribuição Acumulada dos Cenários para o Subsistema Nordeste para o PMO de Agosto/2025

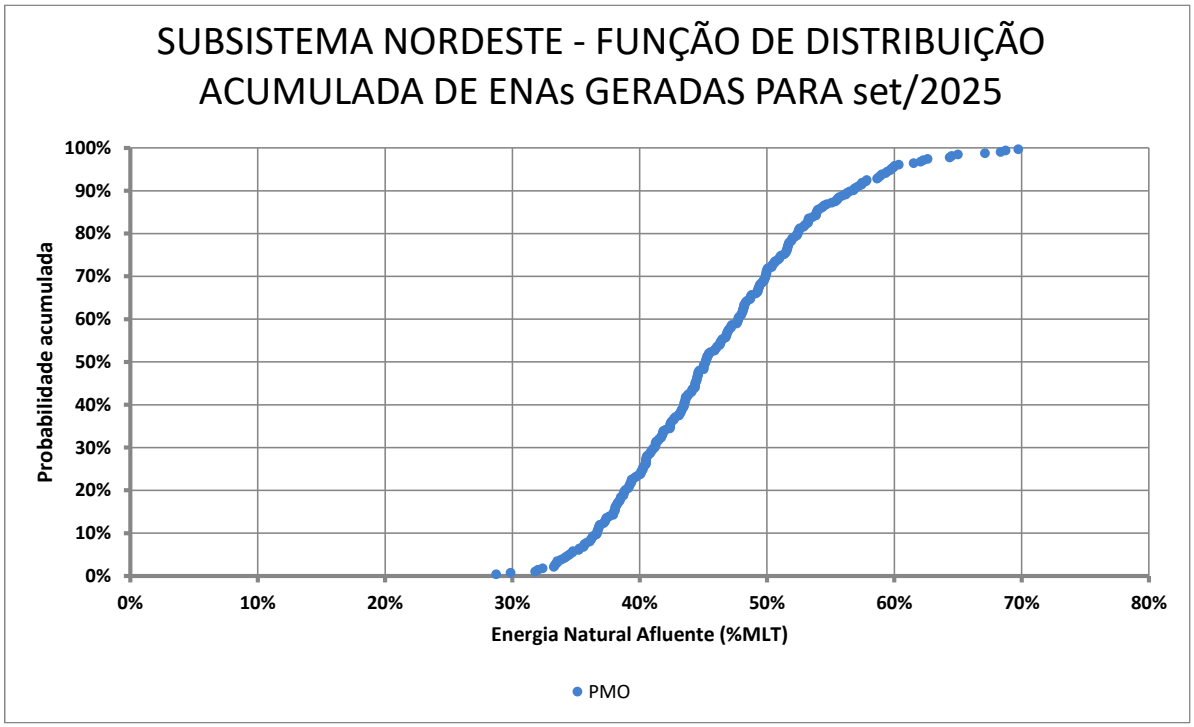

O conteúdo desta publicação foi produzido pelo ONS com base em dados e informações de conhecimento público. É de responsabilidade exclusiva dos agentes e demais interessados a obtenção de outros dados e informações, a realização de análises, estudos e avaliações para fins de tomada de decisões, definição de estratégias de atuação, assunção de compromissos e obrigações e quaisquer outras finalidades, em qualquer tempo e sob qualquer condição. É proibida a reprodução ou utilização total ou parcial do presente sem a identificação da fonte.

Figura 22 - Amplitude dos Cenários de ENA para o Subsistema Norte, em %MLT, para o PMO de Agosto/2025

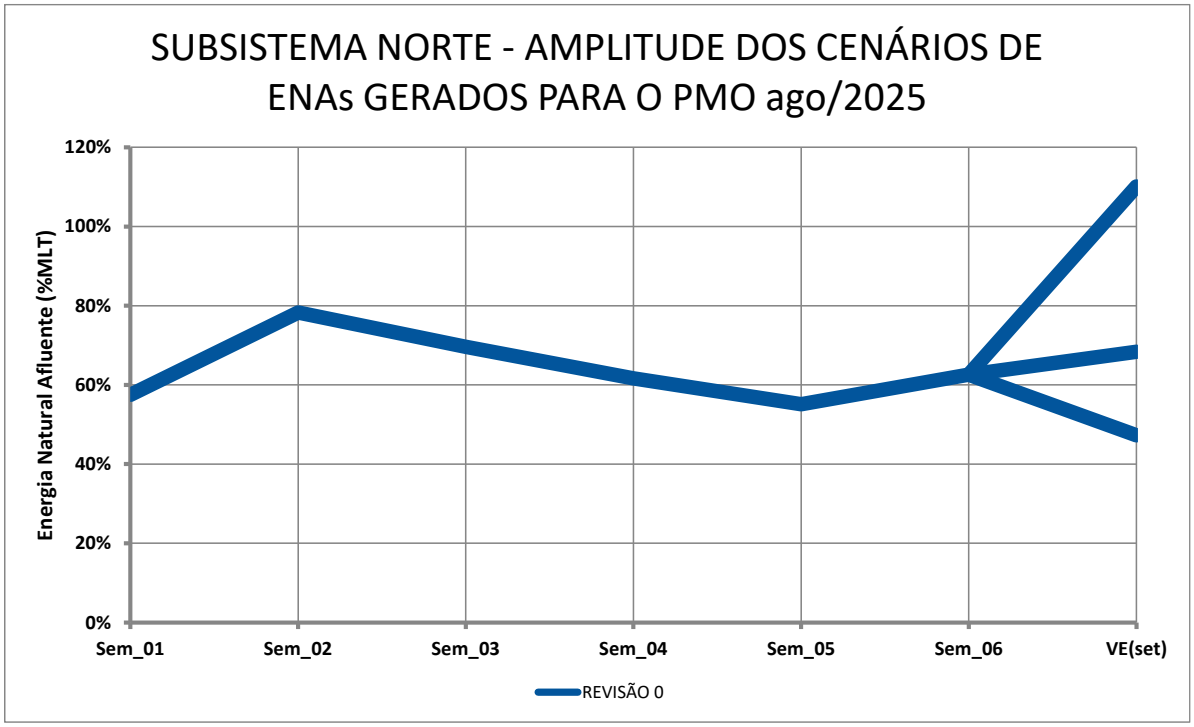

Figura 23 - Função de Distribuição Acumulada dos Cenários para o Subsistema Norte para o PMO de Agosto/2025

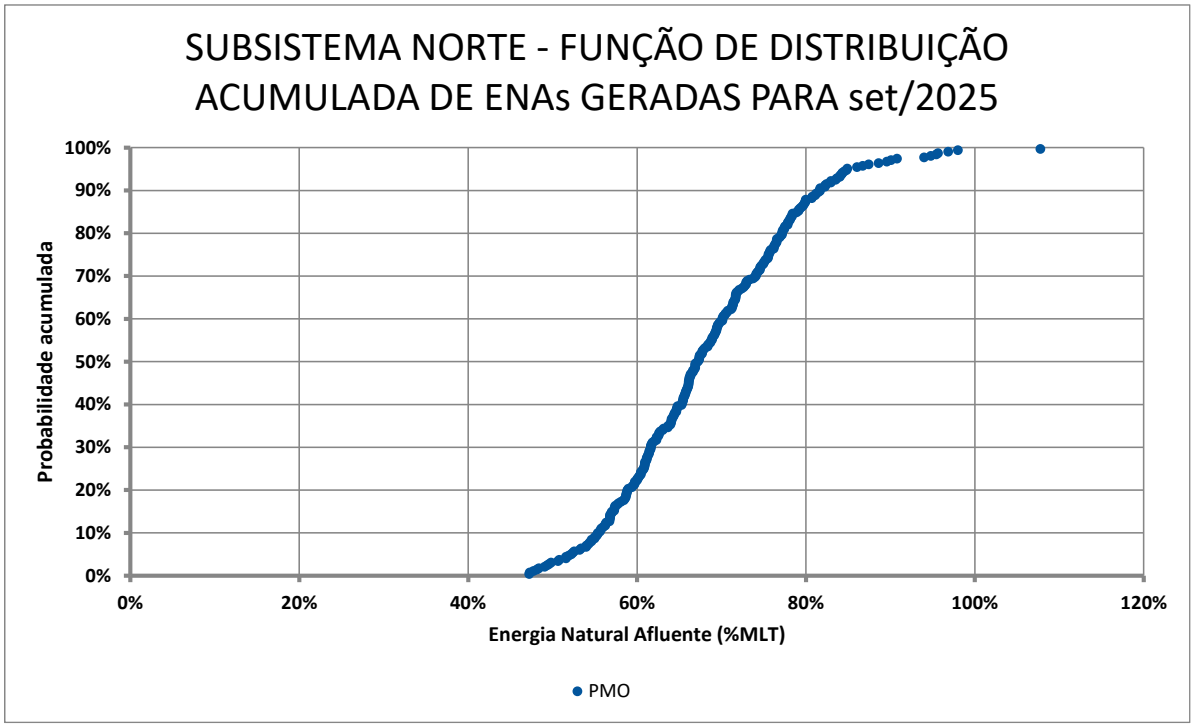

O conteúdo desta publicação foi produzido pelo ONS com base em dados e informações de conhecimento público. É de responsabilidade exclusiva dos agentes e demais interessados a obtenção de outros dados e informações, a realização de análises, estudos e avaliações para fins de tomada de decisões, definição de estratégias de atuação, assunção de compromissos e obrigações e quaisquer outras finalidades, em qualquer tempo e sob qualquer condição. É proibida a reprodução ou utilização total ou parcial do presente sem a identificação da fonte.

Os valores da MLT (Média de Longo Termo) das energias naturais afluentes para os meses de agosto/2025 e setembro/2025 são apresentados na tabela a seguir.

Tabela 9 – MLT da ENA nos meses de agosto/2025 e setembro/2025

MLT das ENAs (MWmed)		
Subsistema	agosto	setembro
SE/CO	20.527	19.629
S	9.984	11.676
NE	3.267	2.923
N	3.174	2.260

4.2. Limites de Intercâmbio entre Subsistemas

Os limites elétricos de intercâmbio de energia entre subsistemas são de fundamental importância para o processo de otimização energética, sendo determinantes para a definição das políticas de operação e do CMO para cada subsistema. Estes limites são influenciados por intervenções na malha de transmissão, notadamente na primeira semana operativa. O diagrama a seguir ilustra os fluxos notáveis do SIN e os limites aplicados neste PMO.

Figura 24 – Interligações entre regiões

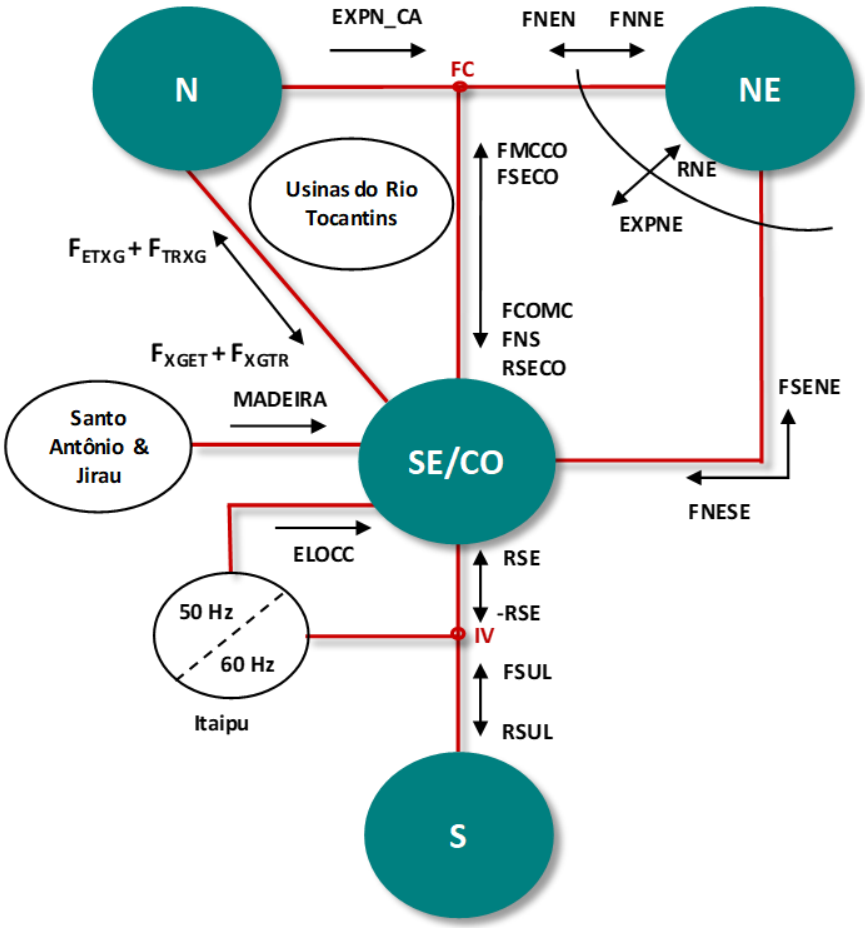

O conteúdo desta publicação foi produzido pelo ONS com base em dados e informações de conhecimento público. É de responsabilidade exclusiva dos agentes e demais interessados a obtenção de outros dados e informações, a realização de análises, estudos e avaliações para fins de tomada de decisões, definição de estratégias de atuação, assunção de compromissos e obrigações e quaisquer outras finalidades, em qualquer tempo e sob qualquer condição. É proibida a reprodução ou utilização total ou parcial do presente sem a identificação da fonte.

Tabela 10 – Limites considerados nesta semana operativa para intercâmbio de energia

Limites de Intercâmbio (MWmed)				
Fluxo	Patamar	26/07 a 01/08/2025		Demais Semanas
RNE	Pesada	11.000		11.000
	Média	11.000		11.000
	Leve	11.000		11.000
FNS	Pesada	**4.900**	(A) (B) (C)	5.200
	Média	**4.931**		5.200
	Leve	**4.364**		5.000
FNNE	Pesada	**4.480**	(D) (K)	4.600
	Média	**4.498**		4.600
	Leve	**4.585**		4.600
EXPORT. NE	Pesada	13.800		13.800
	Média	13.800		13.800
	Leve	13.800		13.800
FMCCO	Pesada	5.000		5.000
	Média	5.000		5.000
	Leve	5.000		5.000
FSENE	Pesada	6.000		6.000
	Média	6.000		6.000
	Leve	6.000		6.000
FNS + FNESE	Pesada	**10.900**	(A) (C)	11.200
	Média	**9.877**		10.146
	Leve	**11.015**		11.200
RSE	Pesada	**9.200**	(E)	10.200
	Média	**9.354**		10.200
	Leve	**10.527**		10.880
FORNEC. SUL	Pesada	7.000		7.000
	Média	7.000		7.000
	Leve	8.600		8.600

Limites de Intercâmbio (MWmed)				
Fluxo	Patamar	26/07 a 01/08/2025		Demais Semanas
RECEB. SUL	Pesada	**9.400**	(E) (F) (G)	9.600
	Média	**5.881**		6.050
	Leve	**10.329**		10.400
ELO CC 50 Hz	Pesada	3.132		3.132
	Média	3.132		3.132
	Leve	3.132		3.132
ITAIPU 60 Hz	Pesada	**6.460**	(H) (I)	7.500
	Média	**6.620**		7.500
	Leve	**7.200**		7.500
EXP. N CA	Pesada	8.000		8.000
	Média	8.000		8.000
	Leve	8.000		8.000
FETXG + FTRXG	Pesada	4.200		4.200
	Média	4.200		4.200
	Leve	1.000		1.000
FXGET + FXGTR	Pesada	3.000		3.000
	Média	3.000		3.000
	Leve	3.000		3.000
FNESE	Pesada	**7.900**	(D) (J) (K)	8.000
	Média	**7.915**		8.000
	Leve	**7.508**		8.000
FNEN	Pesada	**5.160**	(K)	5.200
	Média	**5.166**		5.200
	Leve	**5.195**		5.200
Ger_MADEIRA	Pesada	7.348	(L)	7.348
	Média	**5.894**		7.348
	Leve	7.348		7.348

(A) SGI 37.299-25
(B) SGI 42.932-25
(C) SGI 36.951-25
(D) SGI 42.161-25
(E) SGI 31.689-25
(F) SGI 42.510-25
(G) SGI 31.732-25
(H) SGI 31.747-25
(I) SGI 42.515-25
(J) SGI 37.428-25
(K) SGI 42.161-25
(L) SGI 36.969-25

O conteúdo desta publicação foi produzido pelo ONS com base em dados e informações de conhecimento público. É de responsabilidade exclusiva dos agentes e demais interessados a obtenção de outros dados e informações, a realização de análises, estudos e avaliações para fins de tomada de decisões, definição de estratégias de atuação, assunção de compromissos e obrigações e quaisquer outras finalidades, em qualquer tempo e sob qualquer condição. É proibida a reprodução ou utilização total ou parcial do presente sem a identificação da fonte.

4.3. Previsão de carga

Em julho de 2025, a atividade econômica seguiu em ritmo moderado, impactada pelos efeitos defasados da política monetária restritiva. A Selic elevada continua limitando o crédito e o consumo, com reflexos mais evidentes na indústria de transformação e nos bens duráveis. Os indicadores de confiança permanecem em patamares reduzidos, refletindo incertezas internas e externas que afetam decisões de produção e investimento, sobretudo em setores energointensivos como metalurgia, papel e produtos químicos. A recuperação contida do mercado de trabalho e a estabilidade da renda também restringem a demanda. Esse cenário tende a moderar o avanço do consumo de energia elétrica, especialmente nas regiões com maior peso industrial na carga do SIN.

Com base no fechamento do PMO de agosto, as projeções de carga indicam variações de -2,7% no Subsistema Sudeste/Centro-Oeste, 3,5% no Sul, 0,3% no Nordeste e 2,4% no Norte, em relação ao mesmo mês de 2024. Os principais fatores que explicam essas variações são detalhados a seguir.

A carga global de energia estimada para a semana operativa atual (19/07 a 25/07) no SIN é 1,5% superior à da semana anterior (12/07 a 18/07), totalizando 75.536 MW médios. O crescimento da carga no final de julho reflete o aumento observado em todos os subsistemas na comparação com a semana anterior. Os maiores destaques foram o Nordeste (2,3%), Norte (1,9%) e Sul (1,8%). Já o Sudeste/Centro-Oeste registrou aumento mais modesto, de 1,2%, influenciada pela estabilidade das temperaturas entre as semanas (máximas entre 23 °C e 28 °C).

Para a próxima semana operativa (26/07 a 01/08), projeta-se alta de 0,5% na carga do SIN frente à semana atual. As previsões indicam aumento de temperatura em São Paulo e Rio de Janeiro, além de estabilidade térmica e nos volumes de precipitação nos demais subsistemas. O Sudeste deve registrar máximas entre 26 °C e 31 °C, e o Sul entre 19 °C e 23 °C. Para agosto, são esperadas temperaturas acima da média histórica, com ausência de anomalias de precipitação, caracterizando um mês seco.

Tabela 11 – Evolução da carga do PMO de Agosto de 2025

Subsistema	CARGA SEMANAL (MWmed)						CARGA MENSAL (MWmed)	
	1ª Sem	2ª Sem	3ª Sem	4ª Sem	5ª Sem	6ª Sem	ago/25	Var. (%) ago/25 -> ago/24
SE/CO	41.995	41.907	41.834	42.367	42.376	43.488	42.205	-2,7%
Sul	13.541	13.536	13.541	13.564	13.549	13.586	13.550	3,5%
Nordeste	12.328	12.638	12.705	12.851	12.977	12.920	12.786	0,3%
Norte	8.042	8.172	8.193	8.349	8.364	8.363	8.268	2,4%
SIN	**75.906**	**76.253**	**76.273**	**77.131**	**77.266**	**78.357**	**76.809**	**-0,6%**

O conteúdo desta publicação foi produzido pelo ONS com base em dados e informações de conhecimento público. É de responsabilidade exclusiva dos agentes e demais interessados a obtenção de outros dados e informações, a realização de análises, estudos e avaliações para fins de tomada de decisões, definição de estratégias de atuação, assunção de compromissos e obrigações e quaisquer outras finalidades, em qualquer tempo e sob qualquer condição. É proibida a reprodução ou utilização total ou parcial do presente sem a identificação da fonte.

4.4. Potência Hidráulica Total Disponível no SIN

O gráfico a seguir mostra a disponibilidade hidráulica total do SIN, para este mês, de acordo com o cronograma de manutenção informado pelos agentes para este PMO.

Figura 25 – Potência hidráulica disponível no SIN

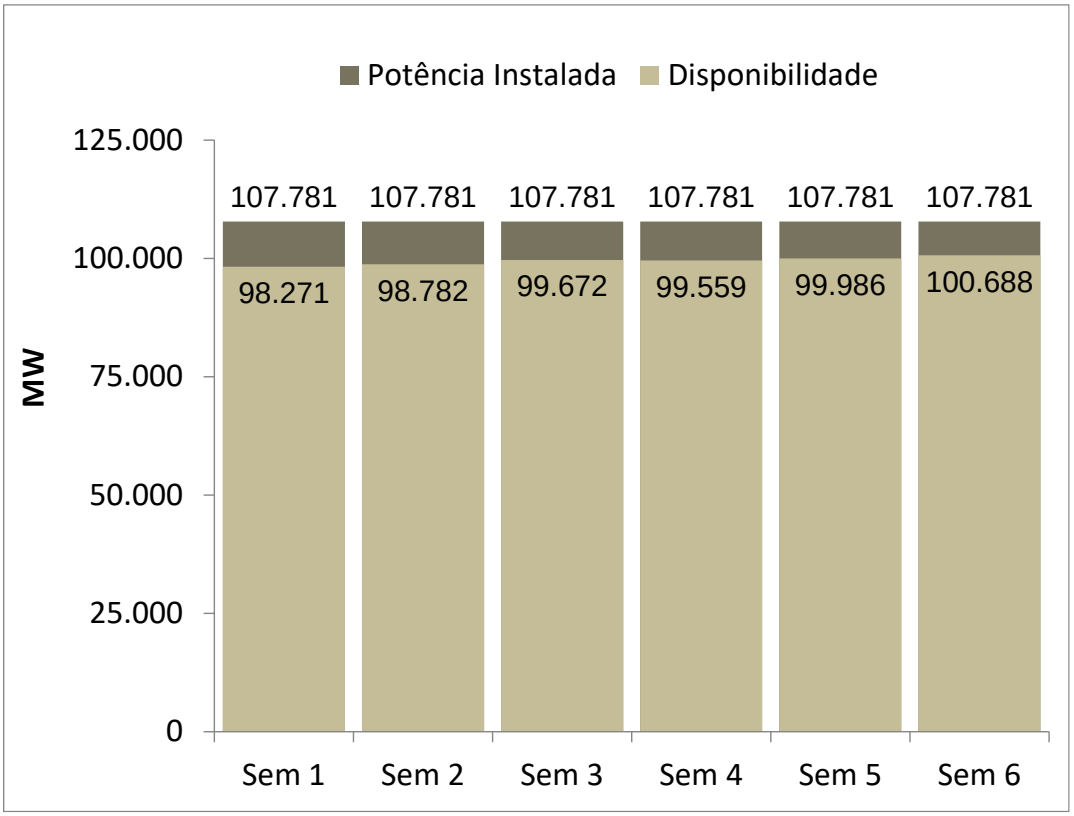

4.5. Armazenamentos Iniciais por Subsistema

Tabela 12 – Armazenamentos iniciais, por subsistema, considerados para esta semana operativa

Armazenamento (%EARmáx) - 0:00 h do dia 26/07/2025		
Subsistema	**Nível previsto na Revisão 3 do PMO Jul/2025**	**Partida informada pelos Agentes para o PMO Ago/2025**
SE/CO	64,3	64,0
S	90,0	87,4
NE	65,7	65,8
N	95,5	94,1

A primeira coluna da tabela acima corresponde ao armazenamento previsto na Revisão 3 do PMO de Julho de 2025, para a 0:00 h do dia 26/07/2025. A segunda coluna apresenta os armazenamentos obtidos a partir dos níveis de partida informados pelos Agentes de Geração para seus aproveitamentos com reservatórios.

O conteúdo desta publicação foi produzido pelo ONS com base em dados e informações de conhecimento público. É de responsabilidade exclusiva dos agentes e demais interessados a obtenção de outros dados e informações, a realização de análises, estudos e avaliações para fins de tomada de decisões, definição de estratégias de atuação, assunção de compromissos e obrigações e quaisquer outras finalidades, em qualquer tempo e sob qualquer condição. É proibida a reprodução ou utilização total ou parcial do presente sem a identificação da fonte.

5. PRINCIPAIS RESULTADOS

5.1. Política de Operação Energética

Para esta semana operativa, está prevista a seguinte política de intercâmbio de energia entre regiões:

Região SE/CO:

- Geração dimensionada para controle de nível e atendimento nos períodos de carga média e pesada;

- Alocação da Folga de Potência Monitorada nas usinas de cabeceira dos rios Grande e Paranaíba.

Região Sul:

- Geração dimensionada para controle de nível em função das condições hidrológicas. Atendimento em todos os períodos de carga do SIN.

Região NE:

- Geração hidráulica em atendimento à Res. ANA 2.081/2017 minimizada para alocação de geração renováveis do NE.

Região Norte:

- Exploração dos recursos em função das disponibilidades energéticas;

- Alocação da Folga de Potência Monitorada nas usinas do rio Tocantins.

5.2. Custo Marginal de Operação – CMO

A figura a seguir apresenta os Custos Marginais de Operação, em valores médios semanais, para as semanas operativas deste mês.

Figura 26 – CMO em valores médios

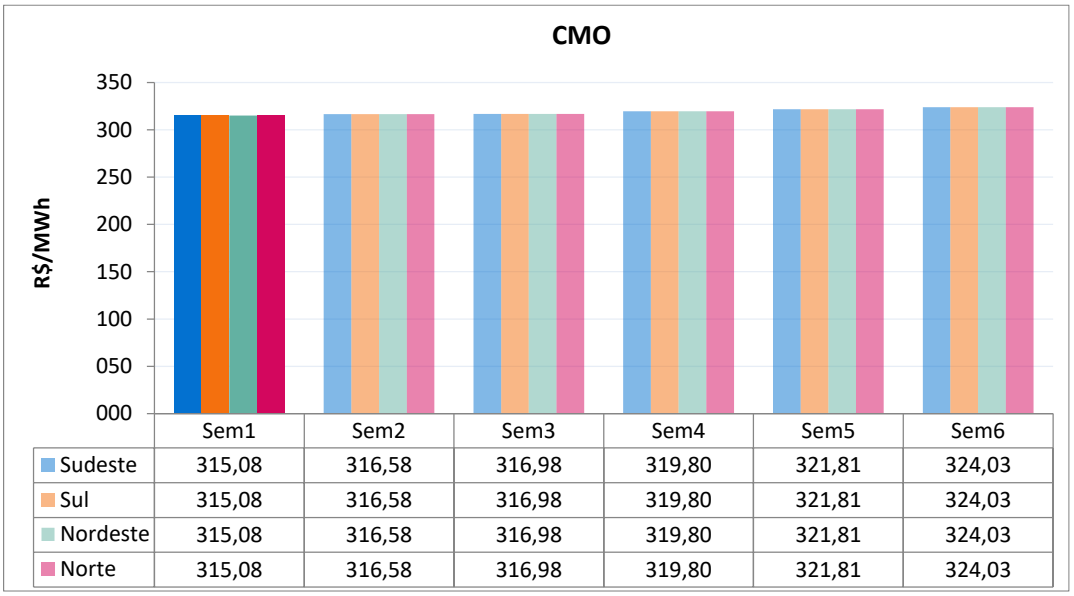

	Sem1	Sem2	Sem3	Sem4	Sem5	Sem6
Sudeste	315,08	316,58	316,98	319,80	321,81	324,03
Sul	315,08	316,58	316,98	319,80	321,81	324,03
Nordeste	315,08	316,58	316,98	319,80	321,81	324,03
Norte	315,08	316,58	316,98	319,80	321,81	324,03

O conteúdo desta publicação foi produzido pelo ONS com base em dados e informações de conhecimento público. É de responsabilidade exclusiva dos agentes e demais interessados a obtenção de outros dados e informações, a realização de análises, estudos e avaliações para fins de tomada de decisões, definição de estratégias de atuação, assunção de compromissos e obrigações e quaisquer outras finalidades, em qualquer tempo e sob qualquer condição. É proibida a reprodução ou utilização total ou parcial do presente sem a identificação da fonte.

A tabela a seguir apresenta o custo marginal de operação, por subsistema e patamar de carga, para a próxima semana operativa.

Tabela 13 – CMO para esta semana operativa

Patamares de Carga	CMO (R$/MWh)			
	SE/CO	S	NE	N
Pesada	324,03	324,03	324,03	324,03
Média	317,31	317,31	317,31	317,31
Leve	310,35	310,35	310,35	310,35
Média Semanal	315,08	315,08	315,08	315,08

5.3. Energia Armazenada

O processo de otimização realizado pelo programa DECOMP indicou os armazenamentos mostrados na figura a seguir para as próximas semanas operativas do mês de agosto/2025.

Figura 27 – Energias Armazenadas nas semanas operativas do mês de agosto/2025

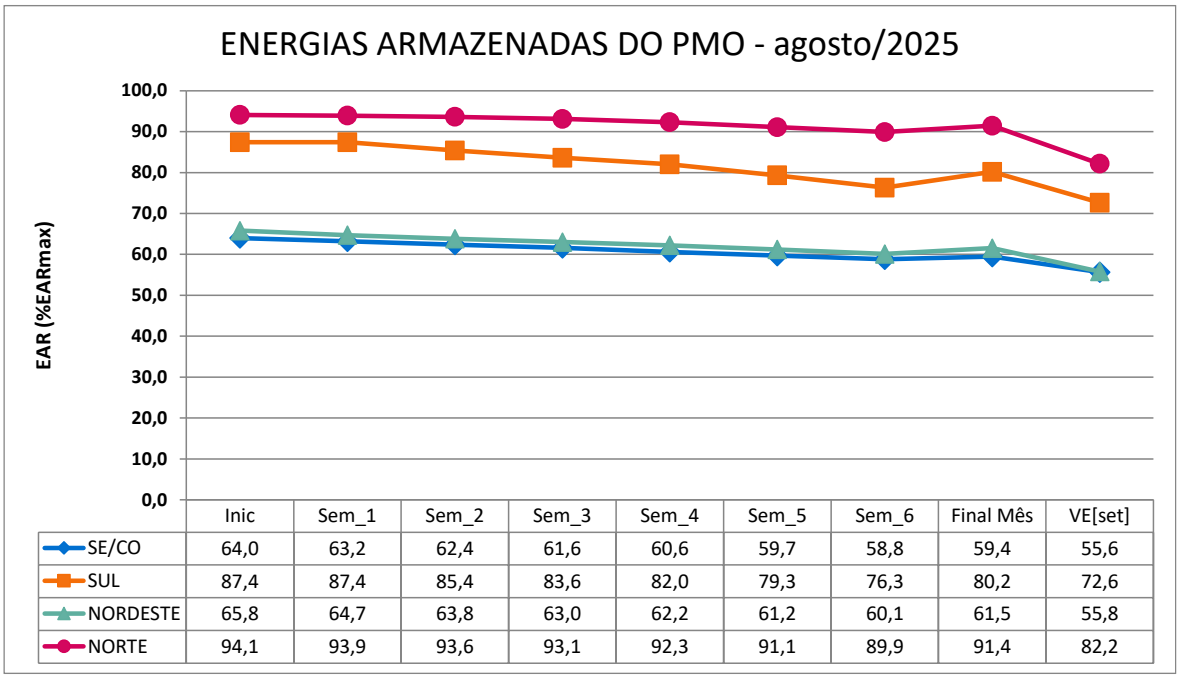

	Inic	Sem_1	Sem_2	Sem_3	Sem_4	Sem_5	Sem_6	Final Mês	VE[set]
SE/CO	64,0	63,2	62,4	61,6	60,6	59,7	58,8	59,4	55,6
SUL	87,4	87,4	85,4	83,6	82,0	79,3	76,3	80,2	72,6
NORDESTE	65,8	64,7	63,8	63,0	62,2	61,2	60,1	61,5	55,8
NORTE	94,1	93,9	93,6	93,1	92,3	91,1	89,9	91,4	82,2

Os armazenamentos da figura anterior estão expressos em percentual da Energia Armazenável Máxima de cada subsistema, que são mostradas na tabela a seguir.

Tabela 14 – Energia Armazenável Máxima por subsistema no PMO de Agosto/2025

ENERGIA ARMAZENÁVEL MÁXIMA (MWmed)		
Subsistema	agosto	setembro
SE/CO	205.390	205.390
S	20.458	20.458
NE	51.718	51.718
N	15.689	15.842

O conteúdo desta publicação foi produzido pelo ONS com base em dados e informações de conhecimento público. É de responsabilidade exclusiva dos agentes e demais interessados a obtenção de outros dados e informações, a realização de análises, estudos e avaliações para fins de tomada de decisões, definição de estratégias de atuação, assunção de compromissos e obrigações e quaisquer outras finalidades, em qualquer tempo e sob qualquer condição. É proibida a reprodução ou utilização total ou parcial do presente sem a identificação da fonte.

6. GERAÇÃO TÉRMICA

A Figura 28 apresenta, para cada subsistema do SIN, o despacho térmico por modalidade indicado pelo Decomp para esta semana operativa.

Figura 28 – Geração térmica para a próxima semana operativa

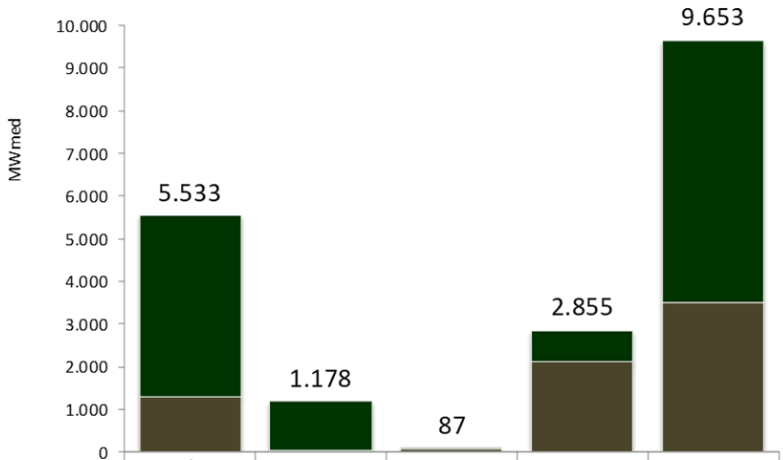

	SE/CO	SUL	NE	NORTE	SIN
TOTAL	5.533	1.178	87	2.855	9.653
RESTRIÇÃO ELÉTRICA	0	0	0	0	0
INFLEXIBILIDADE	4243	1155	4	755	6157
ORDEM DE MÉRITO	1290	23	83	2100	3496

O gráfico a seguir apresenta a expectativa de despacho Térmico para os dois meses do horizonte de estudo.

Figura 29 – Expectativa de despacho térmico para o horizonte de dois meses

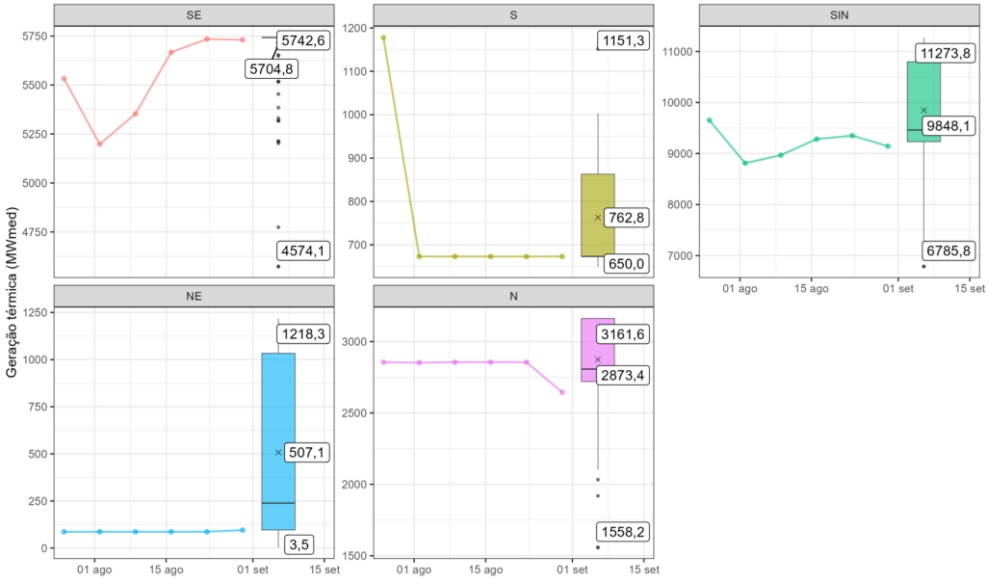

O conteúdo desta publicação foi produzido pelo ONS com base em dados e informações de conhecimento público. É de responsabilidade exclusiva dos agentes e demais interessados a obtenção de outros dados e informações, a realização de análises, estudos e avaliações para fins de tomada de decisões, definição de estratégias de atuação, assunção de compromissos e obrigações e quaisquer outras finalidades, em qualquer tempo e sob qualquer condição. É proibida a reprodução ou utilização total ou parcial do presente sem a identificação da fonte.

Na tabela abaixo segue a Indicação de despacho antecipado por ordem de mérito de custo para a semana de 27/09/2025 a 03/10/2025.

Tabela 15 – UTEs com contrato de combustível GNL

UTE			Benefício (R$/MWh)			Despacho antecipado por mérito		
Nome	Código	CVU (R$/MWh)	Carga Pesada	Carga Média	Carga Leve	Carga Pesada	Carga Média	Carga Leve
SANTA CRUZ	86	229,99	345,73	336,51	329,24	Sim	Sim	Sim
LUIZORMELO	15	347,91	345,73	336,51	329,24	Não	Não	Não
PSERGIPE I	224	338,64	345,63	336,49	329,24	Sim	Não	Não

Assim sendo, há previsão de despacho antecipado por ordem de mérito de custo para as UTE Santa Cruz em todos os patamares de carga e Porto Sergipe I no patamar de carga pesada, para a semana de 27/09/2025 a 03/10/2025.

Para a UTE Luiz O. R. Melo não há indicação de despacho antecipado para a referida semana.

O conteúdo desta publicação foi produzido pelo ONS com base em dados e informações de conhecimento público. É de responsabilidade exclusiva dos agentes e demais interessados a obtenção de outros dados e informações, a realização de análises, estudos e avaliações para fins de tomada de decisões, definição de estratégias de atuação, assunção de compromissos e obrigações e quaisquer outras finalidades, em qualquer tempo e sob qualquer condição. É proibida a reprodução ou utilização total ou parcial do presente sem a identificação da fonte.

7. RESUMO DOS RESULTADOS DO PMO

As figuras a seguir apresentam um resumo dos resultados do PMO de Agosto/2025, com informações da Energia Natural Afluente (ENA), da Energia Armazenada (EAR) e do Custo Marginal de Operação (CMO) nos subsistemas do Sistema Interligado Nacional (SIN). São apresentados os valores semanais observados e previstos e o valor esperado dos cenários gerados para o mês de setembro/2025.

Figura 30 – Resumo de agosto/2025 para o Subsistema Sudeste/Centro-Oeste

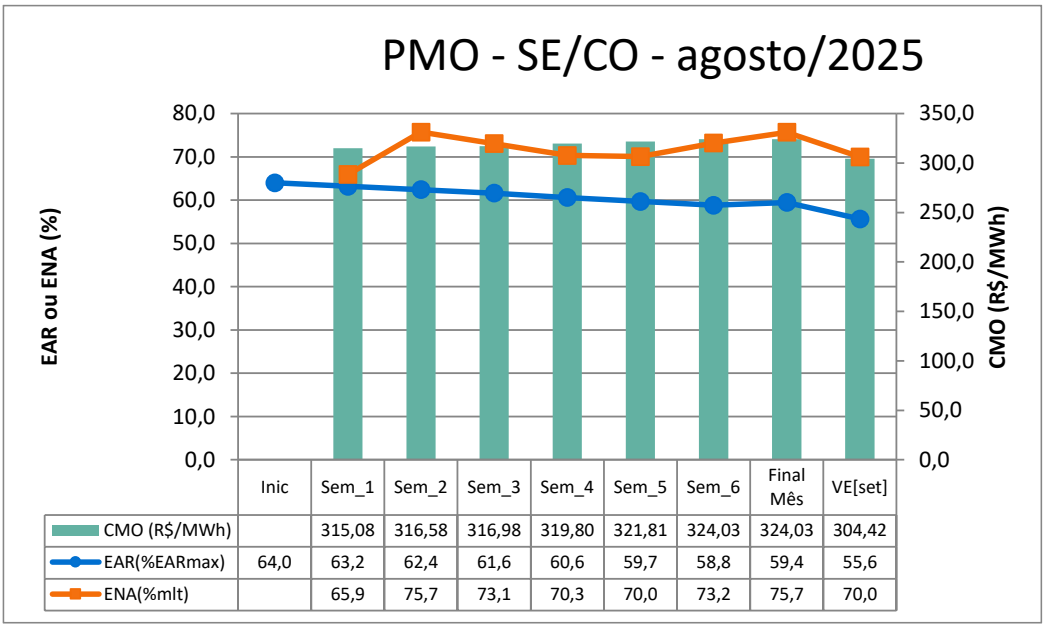

	Inic	Sem_1	Sem_2	Sem_3	Sem_4	Sem_5	Sem_6	Final Mês	VE[set]
CMO (R$/MWh)		315,08	316,58	316,98	319,80	321,81	324,03	324,03	304,42
EAR(%EARmax)	64,0	63,2	62,4	61,6	60,6	59,7	58,8	59,4	55,6
ENA(%mlt)		65,9	75,7	73,1	70,3	70,0	73,2	75,7	70,0

Figura 31 – Resumo de agosto/2025 para o Subsistema Sul

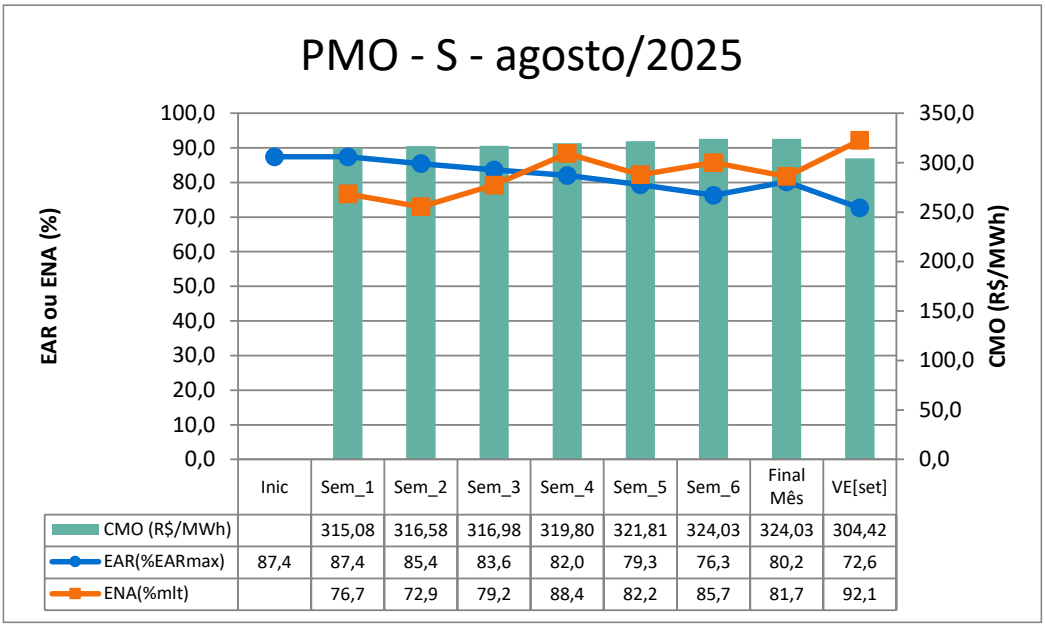

	Inic	Sem_1	Sem_2	Sem_3	Sem_4	Sem_5	Sem_6	Final Mês	VE[set]
CMO (R$/MWh)		315,08	316,58	316,98	319,80	321,81	324,03	324,03	304,42
EAR(%EARmax)	87,4	87,4	85,4	83,6	82,0	79,3	76,3	80,2	72,6
ENA(%mlt)		76,7	72,9	79,2	88,4	82,2	85,7	81,7	92,1

O conteúdo desta publicação foi produzido pelo ONS com base em dados e informações de conhecimento público. É de responsabilidade exclusiva dos agentes e demais interessados a obtenção de outros dados e informações, a realização de análises, estudos e avaliações para fins de tomada de decisões, definição de estratégias de atuação, assunção de compromissos e obrigações e quaisquer outras finalidades, em qualquer tempo e sob qualquer condição. É proibida a reprodução ou utilização total ou parcial do presente sem a identificação da fonte.

Figura 32 – Resumo de agosto/2025 para o Subsistema Nordeste

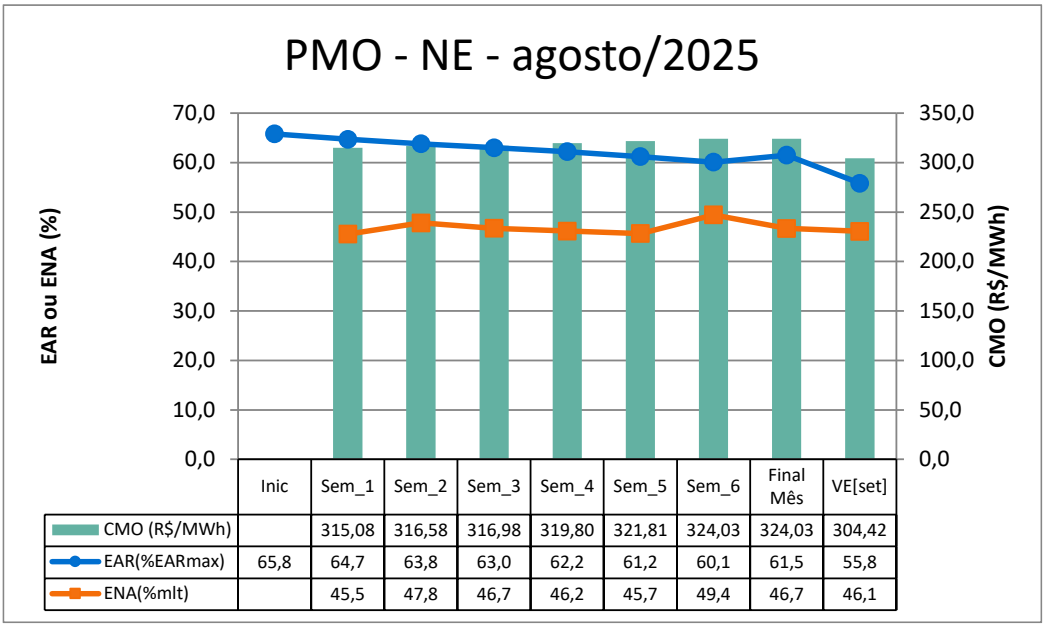

	Inic	Sem_1	Sem_2	Sem_3	Sem_4	Sem_5	Sem_6	Final Mês	VE[set]
CMO (R$/MWh)		315,08	316,58	316,98	319,80	321,81	324,03	324,03	304,42
EAR(%EARmax)	65,8	64,7	63,8	63,0	62,2	61,2	60,1	61,5	55,8
ENA(%mlt)		45,5	47,8	46,7	46,2	45,7	49,4	46,7	46,1

Figura 33 – Resumo de agosto/2025 para o Subsistema Norte

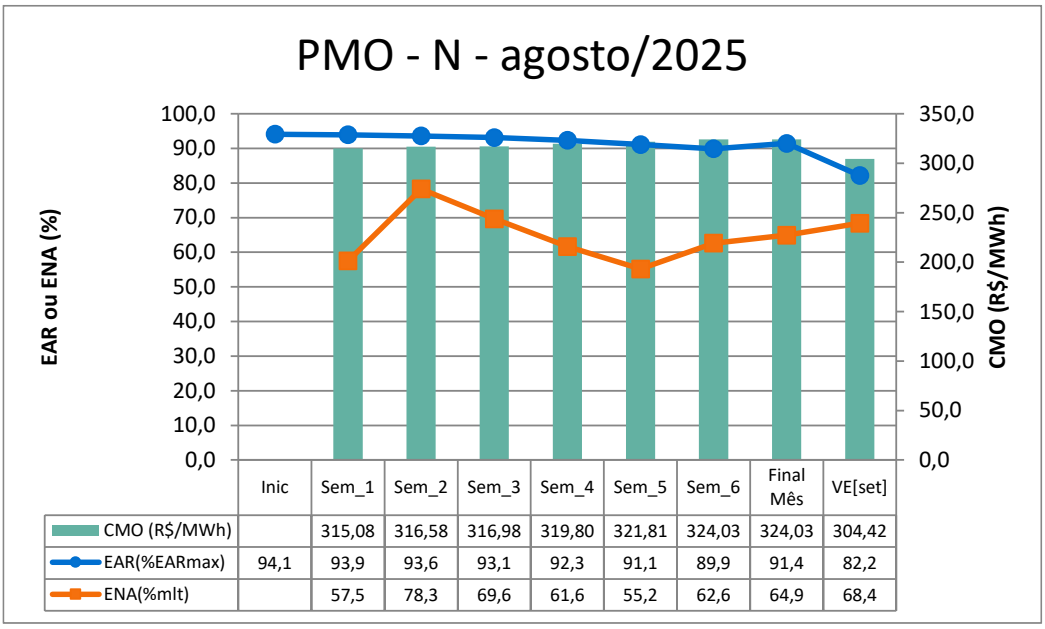

	Inic	Sem_1	Sem_2	Sem_3	Sem_4	Sem_5	Sem_6	Final Mês	VE[set]
CMO (R$/MWh)		315,08	316,58	316,98	319,80	321,81	324,03	324,03	304,42
EAR(%EARmax)	94,1	93,9	93,6	93,1	92,3	91,1	89,9	91,4	82,2
ENA(%mlt)		57,5	78,3	69,6	61,6	55,2	62,6	64,9	68,4

O conteúdo desta publicação foi produzido pelo ONS com base em dados e informações de conhecimento público. É de responsabilidade exclusiva dos agentes e demais interessados a obtenção de outros dados e informações, a realização de análises, estudos e avaliações para fins de tomada de decisões, definição de estratégias de atuação, assunção de compromissos e obrigações e quaisquer outras finalidades, em qualquer tempo e sob qualquer condição. É proibida a reprodução ou utilização total ou parcial do presente sem a identificação da fonte.

8. ARMAZENAMENTOS OPERATIVOS

Para uma melhor avaliação de diversos cenários hidrometeorológicos, notadamente, aqueles de curto prazo e suas influências nas previsões de vazões nos subsistemas, os resultados deste PMO contemplam cenários de afluências visando melhor representar a ocorrência de precipitação e, consequentemente, seus efeitos sobre as afluências e armazenamentos.

Apresentamos a seguir as correspondentes energias naturais afluentes e os resultados obtidos com a aplicação do cenário de afluência utilizado no estudo.

Tabela 16 – Previsão de ENA do caso de valor esperado das previsões de afluência

Subsistema	ENERGIAS NATURAIS AFLUENTES			
	Previsão Semanal		Previsão Mensal	
	(MWmed)	%MLT	(MWmed)	%MLT
SE/CO	17.017	68	15.530	76
Sul	8.293	77	8.163	82
Nordeste	1.674	46	1.525	47
Norte	2.712	55	2.060	65

Tabela 17 – Previsão de %EARmáx para o final do mês

Subsistema	% EARmáx 25/07	% EARmáx - 31/08
	NÍVEL INICIAL	NÍVEL PMO
SE/CO	64,0	59,4
Sul	87,4	78,4
Nordeste	65,8	60,9
Norte	94,1	90,8

O conteúdo desta publicação foi produzido pelo ONS com base em dados e informações de conhecimento público. É de responsabilidade exclusiva dos agentes e demais interessados a obtenção de outros dados e informações, a realização de análises, estudos e avaliações para fins de tomada de decisões, definição de estratégias de atuação, assunção de compromissos e obrigações e quaisquer outras finalidades, em qualquer tempo e sob qualquer condição. É proibida a reprodução ou utilização total ou parcial do presente sem a identificação da fonte.

9. RESERVATÓRIOS EQUIVALENTES DE ENERGIA

A seguir são apresentadas as previsões de Energia Natural Afluente para a próxima semana operativa e para o mês de agosto, bem como as previsões de Energia Armazenada nos Reservatórios Equivalentes de Energia – REE, deste PMO de Agosto de 2025.

Tabela 18 – Previsão de ENA por REE

Valor Esperado das Energias Naturais Afluentes				
REE	Previsão Semanal		Previsão Mensal	
	26/07/2025 a 01/08/2025		ago/25	
	(MWmed)	%MLT	(MWmed)	%MLT
Sudeste	1.626	56	1.529	61
Madeira	3.364	93	2.469	104
Teles Pires	633	65	546	69
Itaipu	2.106	70	2.115	81
Paraná	7.588	63	7.013	68
Paranapanema	1.065	48	1.198	64
Sul	5.092	84	4.953	83
Iguaçu	3.202	67	3.210	80
Nordeste	1.674	46	1.525	47
Norte	1.217	49	1.007	55
Belo Monte	781	52	450	67
Manaus	845	86	633	93

Tabela 19 – Previsão de %EARmáx por REE

% Energia Armazenável Máxima		
REE	Previsão Semanal	Previsão Mensal
	01-ago	31-ago
	(%EARmáx)	(%EARmáx)
Sudeste	65,9	62,7
Madeira	65,5	56,8
Teles Pires	70,4	66,5
Itaipu	77,3	100,0
Paraná	62,3	57,7
Paranapanema	61,8	63,8
Sul	86,1	75,9
Iguaçu	88,5	80,8
Nordeste	64,7	60,9
Norte	93,9	90,7
Belo Monte	100,0	100,0
Manaus	94,8	91,2

O conteúdo desta publicação foi produzido pelo ONS com base em dados e informações de conhecimento público. É de responsabilidade exclusiva dos agentes e demais interessados a obtenção de outros dados e informações, a realização de análises, estudos e avaliações para fins de tomada de decisões, definição de estratégias de atuação, assunção de compromissos e obrigações e quaisquer outras finalidades, em qualquer tempo e sob qualquer condição. É proibida a reprodução ou utilização total ou parcial do presente sem a identificação da fonte.

10. DESPACHO TÉRMICO POR MODALIDADE, PATAMAR DE CARGA E USINA

Nas tabelas abaixo, a diferenciação entre geração por inflexibilidade e por ordem de mérito tem caráter informativo, com o objetivo de detalhar a informação de inflexibilidade enviada pelos respectivos agentes para o PMO. Ressalta-se que nas etapas de Programação Diária e Tempo Real, o montante despachado nas usinas termelétricas indicadas por ordem de mérito é plenamente intitulado como ordem de mérito.

REGIÃO SUDESTE/CENTRO-OESTE																	
Térmicas Potência (MW)	Combustível	CVU (R$/MWh)	Inflexibilidade			Ordem de Mérito			Total Mérito e INFL.			Razão Elétrica			Total UTE		
			P	M	L	P	M	L	P	M	L	P	M	L	P	M	L
ATLAN_CSA (255)	Resíduos	0,00	125,4	125,4	125,4				125,4	125,4	125,4				125,4	125,4	125,4
DAIA (44)	Diesel	---															
TNORTE 2 (349)	Óleo	---															
W.ARJONA O (177)	Diesel	---															
XAVANTES (54)	Diesel	---															
ANGRA 2 (1350)	Nuclear	20,12	1350,0	1350,0	1350,0	0,0	0,0	0,0	1350,0	1350,0	1350,0				1350,0	1350,0	1350,0
ANGRA 1 (640)	Nuclear	31,17	640,0	640,0	640,0	0,0	0,0	0,0	640,0	640,0	640,0				640,0	640,0	640,0
O.PINTADA (50)	Biomassa	145,52				50,0	50,0	50,0	50,0	50,0	50,0				50,0	50,0	50,0
M.AZUL (566)	Gás	148,65				565,5	565,5	565,5	565,5	565,5	565,5				565,5	565,5	565,5
UTE STA VI (41)	Biomassa	157,20	18,0	18,0	18,0	23,0	23,0	23,0	41,0	41,0	41,0				41,0	41,0	41,0
BAIXADA FL (530)	Gás	226,28				0,0	81,5	258,2		81,5	258,2				0,0	81,5	258,2
SANTA CRUZ (500)	GNL	229,99				500,0	500,0	500,0	500,0	500,0	500,0				500,0	500,0	500,0
ATLANTICO (235)	Resíduos	261,25	218,7	218,7	218,7	0,0	0,0	0,0	218,7	218,7	218,7				218,7	218,7	218,7
ST.CRUZ 34 (436)	Óleo	310,41															
LUIZORMELO (204)	GNL	347,91															
UTE GNA I (1338)	Gás	438,97															
CUBATAO (216)	Gás	457,66	22,0	36,0	65,0				22,0	36,0	65,0				22,0	36,0	65,0
PIRAT.12 O (200)	Gás	470,34															
UTE GNA II (1673)	Gás	595,77	1672,0	1672,0	1672,0				1672,0	1672,0	1672,0				1672,0	1672,0	1672,0
NORTEFLU (826)	Gás	840,10															
KARKEY 013 (259)	Gás	931,12	31,0	31,0	31,0				31,0	31,0	31,0				31,0	31,0	31,0
KARKEY 019 (116)	Gás	931,12															
T.MACAE (922)	Gás	958,24															
T.LAGOAS (350)	Gás	1060,20															
PORSUD II (78)	Gás	1085,75															
PORSUD I (116)	Gás	1087,05															
CUIABA CC (529)	Gás	1115,58															
IBIRITE (235)	Gás	843,13 / 1117,69*															
TERMORIO (989)	Gás	939,08 / 1122,20*	11,6	15,9	17,6				11,6	15,9	17,6				11,6	15,9	17,6
VIANA (175)	Óleo	1734.64 / 1142,23*															
SEROPEDICA (360)	Gás	1303,31															
J.FORA (87)	Gás	1312,72															
PAULINIA (16)	Gás	1330,08	15,7	15,7	15,7				15,7	15,7	15,7				15,7	15,7	15,7
LORM_PCS (36)	Gás	1358,19															
POVOACAO I (75)	Gás	1358,19															
VIANA I (37)	Gás	1358,19															
PALMEIR_GO (176)	Diesel	1439,12															
W.ARJONA (177)	Gás	1560,51															
NPIRATINGA (572)	Gás	1586,02															
TOTAL SE/CO (14989)			4104,4	4122,7	4153,4	1138,5	1220,0	1396,7	5242,9	5342,7	5550,1	0,0	0,0	0,0	5242,9	5342,7	5550,1

REGIÃO SUL																	
Térmicas Potência (MW)	Combustível	CVU (R$/MWh)	Inflexibilidade			Ordem de Mérito			Total Mérito e INFL.			Razão Elétrica			Total UTE		
			P	M	L	P	M	L	P	M	L	P	M	L	P	M	L
PAMPA SUL (345)	Carvão	101,20	330,0	330,0	330,0	15,0	15,0	15,0	345,0	345,0	345,0				345,0	345,0	345,0
SAO SEPE (8)	Biomassa	113,53				8,0	8,0	8,0	8,0	8,0	8,0				8,0	8,0	8,0
FIGUEIRA (20)	Carvão	330,64															
J.LACER. C (330)	Carvão	341,04	300,0	300,0	300,0				300,0	300,0	300,0				300,0	300,0	300,0
J.LACER. B (220)	Carvão	397,24	110,0	110,0	110,0				110,0	110,0	110,0				110,0	110,0	110,0
J.LAC. A2 (110)	Carvão	406,63	55,0	55,0	55,0				55,0	55,0	55,0				55,0	55,0	55,0
J.LAC. A1 (80)	Carvão	475,13	40,0	40,0	40,0				40,0	40,0	40,0				40,0	40,0	40,0
CANDIOTA_3 (350)	Carvão	523,78	320,0	320,0	320,0				320,0	320,0	320,0				320,0	320,0	320,0
B.BONITA I (10)	Gás	778,35															
URUGUAIANA (640)	Gás	831,68															
ARAUCARIA (484)	Gás	1181,50															
CANOAS (249)	Gás	1359,32															
TOTAL SUL (2846)			1155,0	1155,0	1155,0	23,0	23,0	23,0	1178,0	1178,0	1178,0	0,0	0,0	0,0	1178,0	1178,0	1178,0

*Usinas com dois CVU válidos dentro da semana operativa.

O conteúdo desta publicação foi produzido pelo ONS com base em dados e informações de conhecimento público. É de responsabilidade exclusiva dos agentes e demais interessados a obtenção de outros dados e informações, a realização de análises, estudos e avaliações para fins de tomada de decisões, definição de estratégias de atuação, assunção de compromissos e obrigações e quaisquer outras finalidades, em qualquer tempo e sob qualquer condição. É proibida a reprodução ou utilização total ou parcial do presente sem a identificação da fonte.

REGIÃO NORDESTE

Térmicas Potência (MW)	Combustível	CVU (R$/MWh)	Inflexibilidade			Ordem de Mérito			Total Mérito e INFL.			Razão Elétrica			Total UTE		
			P	M	L	P	M	L	P	M	L	P	M	L	P	M	L
GLOBAL I (149)	Óleo	---															
GLOBAL II (149)	Óleo	---															
MARACANAU (168)	Óleo	---															
PETROLINA (136)	Óleo	---															
POTIGUAR (53)	Diesel	---															
POTIGUAR_3 (66)	Diesel	---															
TERMOCABO (50)	Óleo	---															
TERMONE (171)	Óleo	---															
TERMOPB (171)	Óleo	---															
ERB CANDEI (17)	Biomassa	113,61	3,5	3,5	3,5	8,5	8,5	8,5	12,0	12,0	12,0				12,0	12,0	12,0
PROSP_I (28)	Gás	214,28				18,7	18,7	18,7	18,7	18,7	18,7				18,7	18,7	18,7
PROSP_III (56)	Gás	218,33				56,0	56,0	56,0	56,0	56,0	56,0				56,0	56,0	56,0
P.PECEM1 (720)	Carvão	333,10															
PSERGIPE I (1593)	GNL	338,64															
P.PECEM2 (365)	Carvão	341,29															
PROSP_II (37)	Gás	346,55															
VALE ACU (110)	Gás	450,86															
PERNAMBU_3 (201)	Óleo	872,90															
TERMOPE (550)	Gás	971,11															
SUAPE II (381)	Óleo	1033,69															
T.BAHIA (186)	Gás	1120,67															
TERMOCEARA (223)	Óleo	2181,31															
CAMPINA_GR (169)	Óleo	2296,46															
C.MURICY 2 (144)	Óleo	2491,48															
PECEM 2 (144)	Óleo	2517,48															
TOTAL NE (5749)			3,5	3,5	3,5	83,2	83,2	83,2	86,7	86,7	86,7	0,0	0,0	0,0	86,7	86,7	86,7

REGIÃO NORTE

Térmicas Potência (MW)	Combustível	CVU (R$/MWh)	Inflexibilidade			Ordem de Mérito			Total Mérito e INFL.			Razão Elétrica			Total UTE		
			P	M	L	P	M	L	P	M	L	P	M	L	P	M	L
MARANHAO3 (519)	Gás	110,91	113,0	93,0	51,0	388,5	407,6	462,6	501,5	500,6	513,6				501,5	500,6	513,6
APARECIDA (166)	Gás	113,80	75,0	75,0	75,0	73,0	73,0	73,0	148,0	148,0	148,0				148,0	148,0	148,0
JARAQUI (75)	Gás	113,80	29,0	29,0	29,0	34,0	34,0	34,0	63,0	63,0	63,0				63,0	63,0	63,0
PIRARUCU (73)	Gás	113,80	35,0	35,0	35,0	32,0	32,0	32,0	67,0	67,0	67,0				67,0	67,0	67,0
PORAQUE (85)	Gás	113,80	28,0	28,0	28,0	39,0	39,0	39,0	67,0	67,0	67,0				67,0	67,0	67,0
TAMBAQUI (93)	Gás	113,80	33,0	33,0	33,0	30,0	30,0	30,0	63,0	63,0	63,0				63,0	63,0	63,0
TUCUNARE (73)	Gás	113,80	35,0	35,0	35,0	29,0	29,0	29,0	64,0	64,0	64,0				64,0	64,0	64,0
UTE MAUA 3 (591)	Gás	113,80	264,0	264,0	264,0	326,8	326,8	326,8	590,8	590,8	590,8				590,8	590,8	590,8
MARANHAO V (338)	Gás	212,94				330,0	329,6	335,3	330,0	329,6	335,3				330,0	329,6	335,3
MARANHAOIV (338)	Gás	212,94				330,0	329,6	335,3	330,0	329,6	335,3				330,0	329,6	335,3
PARNAIBA_V (386)	Vapor	228,59				356,1	355,6	362,5	356,1	355,6	362,5				356,1	355,6	362,5
N.VENECIA2 (270)	Gás	294,56	180,0	180,0	180,0	80,5	80,2	83,9	260,5	260,2	263,9				260,5	260,2	263,9
P. ITAQUI (360)	Carvão	333,36															
PARNAIB_IV (56)	Gás	468,61															
GERAMAR2 (166)	Óleo	2007,32															
GERAMAR1 (166)	Óleo	2032,63															
TOTAL NORTE (4045)			792,0	772,0	730,0	2048,9	2066,4	2143,4	2840,9	2838,4	2873,4	0,0	0,0	0,0	2840,9	2838,4	2873,4

O conteúdo desta publicação foi produzido pelo ONS com base em dados e informações de conhecimento público. É de responsabilidade exclusiva dos agentes e demais interessados a obtenção de outros dados e informações, a realização de análises, estudos e avaliações para fins de tomada de decisões, definição de estratégias de atuação, assunção de compromissos e obrigações e quaisquer outras finalidades, em qualquer tempo e sob qualquer condição. É proibida a reprodução ou utilização total ou parcial do presente sem a identificação da fonte.