1. APRESENTAÇÃO

No mês de julho, foi observado precipitação nas bacias hidrográficas da Região Sul, sendo que os totais observados foram acima da média histórica nas bacias dos rios Iguaçu, Paranapanema e no trecho incremental a UHE Itaipu. As demais bacias hidrográficas de interesse do SIN apresentaram totais de precipitação inferiores à média histórica.

Na semana de 20/07 a 26/07/2024 não ocorreu precipitação significativa nas principais bacias do SIN.

Na semana de 27/07 a 02/08/2024 deve ocorrer chuva fraca nas bacias dos rios Jacuí, Taquari-Antas, Uruguai, Iguaçu e em pontos isolados do Paranapanema e do trecho incremental a UHE Itaipu.

Os valores médios semanais do Custo Marginal de Operação – CMO dos subsistemas do SIN sofreram as seguintes alterações em relação à semana anterior:

- SE/CO: de R$ 61,45/MWh para R$ 67,45/MWh
- Sul: de R$ 61,45/MWh para R$ 67,45/MWh
- Nordeste: de R$ 61,45/MWh para R$ 67,45/MWh
- Norte: de R$ 61,45/MWh para R$ 67,45/MWh

Desde o dia 01/01/2020, o despacho por ordem de mérito é indicado diariamente pelos resultados do modelo DESSEM. Assim, o despacho por ordem de mérito semanal, conforme publicado nesse documento, tem caráter apenas informativo. Da mesma forma, desde o dia 01/01/2021, a formação de preço deixou o formato semanal/patamar de carga e passou a ser horário, de acordo também com os resultados do modelo DESSEM.

2. NOTÍCIAS

Nos dias 29 e 30 de agosto será realizada a reunião de elaboração do PMO de Setembro de 2024, com transmissão ao vivo através do site do ONS.

3. INFORMAÇÕES PARA A CONSTRUÇÃO DA FUNÇÃO DE CUSTO FUTURO

A atualização de dados para os estudos energéticos de médio prazo é realizada mensalmente quando da elaboração do PMO, tendo por base as informações fornecidas pela ANEEL, MME, EPE, CCEE e Agentes, além de diversas áreas do ONS.

O conteúdo desta publicação foi produzido pelo ONS com base em dados e informações de conhecimento público. É de responsabilidade exclusiva dos agentes e demais interessados a obtenção de outros dados e informações, a realização de análises, estudos e avaliações para fins de tomada de decisões, definição de estratégias de atuação, assunção de compromissos e obrigações e quaisquer outras finalidades, em qualquer tempo e sob qualquer condição. É proibida a reprodução ou utilização total ou parcial do presente sem a identificação da fonte.

3.1. Informações Estruturais

- **Armazenamentos Iniciais**

Os armazenamentos iniciais equivalentes por subsistema, considerados no modelo NEWAVE, são obtidos a partir dos armazenamentos iniciais dos reservatórios individualizados, utilizados no modelo DECOMP e informados pelos Agentes de Geração para a elaboração do PMO de Agosto/2024.

Estes valores, apresentados na **Figura 1**, a seguir, determinam a condição inicial de energia armazenada nos subsistemas do SIN sendo utilizada como recurso energético quando da definição da política de operação do SIN.

Figura 1 – Energia armazenada inicial em julho/24 e agosto/24

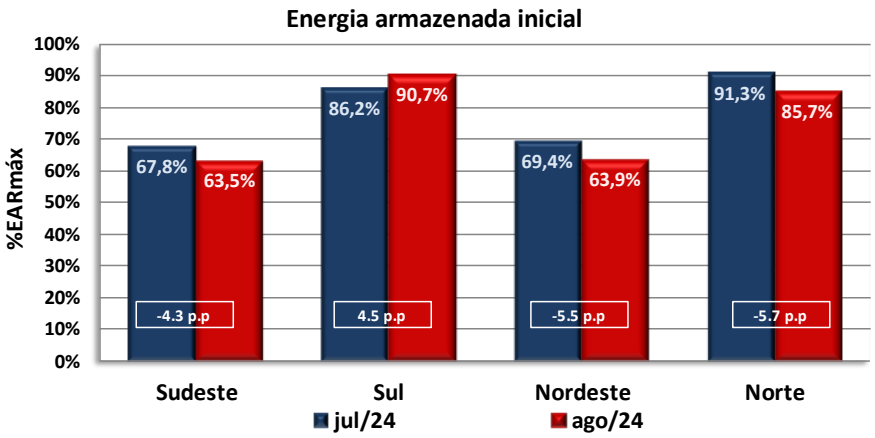

- **Tendência Hidrológica**

Na **Tabela 1** a seguir, são apresentadas as tendências hidrológicas calculadas pelo NEWAVE para o PMO de Agosto/2024, comparadas com o PMO de Julho/2024.

Tabela 1 – Tendência hidrológica para o PMO de Agosto/2024 – NEWAVE [%MLT]

	PMO Julho/2024				PMO Agosto/2024			
MÊS	SE/CO	S	NE	N	SE/CO	S	NE	N
Jan/24	57	137	48	42				
Fev/24	62	87	68	72	62	87	68	72
Mar/24	67	138	61	70	67	138	61	70
Abr/24	85	146	71	84	85	146	71	84
Mai/24	61	343	44	75	60	343	44	75
Jun/24	56	152	40	53	56	153	40	53
Jul/24					59	174	42	51

* ≥100% MLT < 100% MLT

O conteúdo desta publicação foi produzido pelo ONS com base em dados e informações de conhecimento público. É de responsabilidade exclusiva dos agentes e demais interessados a obtenção de outros dados e informações, a realização de análises, estudos e avaliações para fins de tomada de decisões, definição de estratégias de atuação, assunção de compromissos e obrigações e quaisquer outras finalidades, em qualquer tempo e sob qualquer condição. É proibida a reprodução ou utilização total ou parcial do presente sem a identificação da fonte.

No NEWAVE, os cenários de ENA são estimados por um modelo autorregressivo de geração estocástica mensal (GEVAZP "energia") interno ao modelo, cuja ordem máxima está limitada em 6 meses.

Assim, as ENAs verificadas nos 6 meses anteriores constituem uma informação relevante, uma vez que caracterizam a tendência hidrológica da árvore de cenários que será utilizada para a construção da Função de Custo Futuro, com influência direta nos resultados do PMO.

- **Destaques da Expansão da Oferta 2024/2028**

As principais alterações no cronograma, conforme reunião do DPME de 18/07/2024, estão apresentadas nas **Figura 2**, **Figura 3** e **Figura 4**, a seguir, apresentam a evolução da oferta hidroelétrica, termoelétrica e da disponibilidade das usinas não simuladas individualmente, respectivamente, em comparação ao PMO de Julho/2024.

Figura 2 - Evolução da potência instalada das UHEs

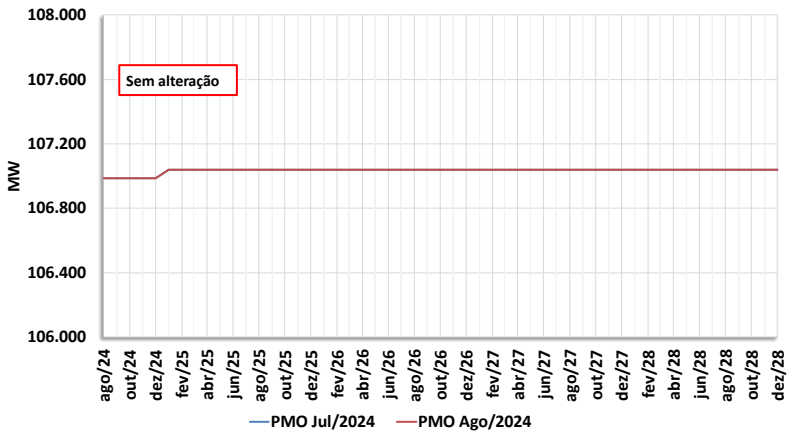

Figura 3 - Evolução da potência instalada das UTEs

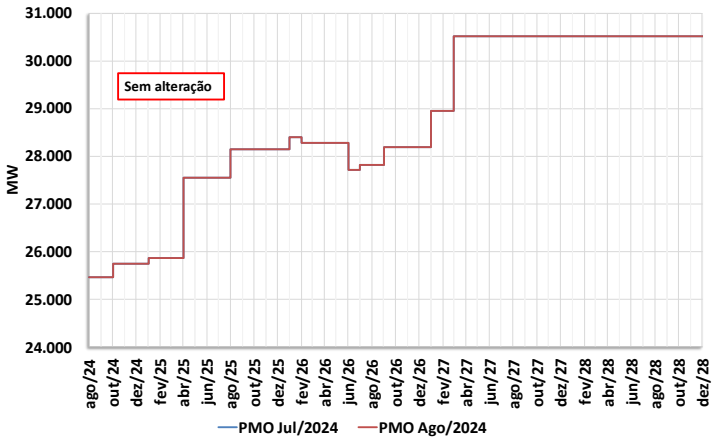

O conteúdo desta publicação foi produzido pelo ONS com base em dados e informações de conhecimento público. É de responsabilidade exclusiva dos agentes e demais interessados a obtenção de outros dados e informações, a realização de análises, estudos e avaliações para fins de tomada de decisões, definição de estratégias de atuação, assunção de compromissos e obrigações e quaisquer outras finalidades, em qualquer tempo e sob qualquer condição. É proibida a reprodução ou utilização total ou parcial do presente sem a identificação da fonte.

Figura 4 - Evolução da disponibilidade das usinas não simuladas

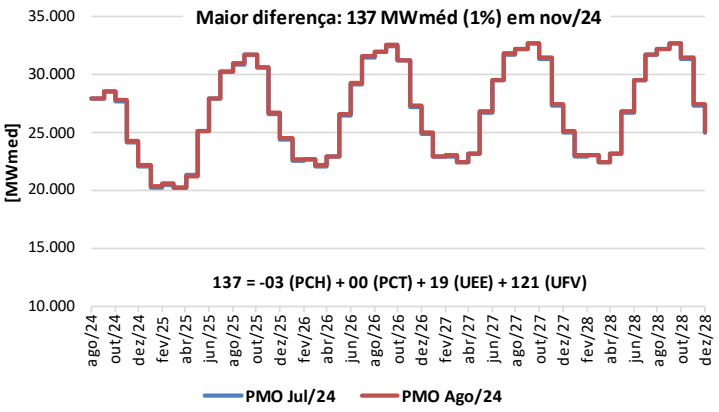

3.2. Modelagem das Restrições de Defluência do rio São Francisco

A partir do PMO de Janeiro de 2023, foi implementada a metodologia de estabelecimento da Curva de Representação dos Condicionantes Hidráulicos (CRCH) para a bacia do rio São Francisco, curva atualizada anualmente, passível de revisões quadrimestrais, e excepcionalmente mensais, que limita a defluência máxima mensal da UHE Xingó nos modelos energéticos, diante da condição de operação do reservatório de Sobradinho na faixa de normal de operação, quando seu volume útil se encontra acima de 60%, bem como a curva definida para o ano de 2023, com divulgação através de FSARH. Tal aprimoramento representará os condicionantes e diretrizes hidráulicas da bacia do rio São Francisco (resolução ANA 2.081/2017). Destaca-se que a partir do PMO de Janeiro de 2024, a modelagem do rio São Francisco segue com a mesma curva e premissas consideradas para o ano de 2023. A Tabela 2 a seguir traz os valores das defluências considerados nesse PMO.

Tabela 2 – Defluência das UHEs Três Marias, Sobradinho, Itaparica, Comp. P. Afonso/Moxotó e Xingó

PMO Atual						
Vazão [m³/s]	Dois primeiros meses				A partir de	
	Ago/24		Set/24		Out/24	
	Qmin	Qmáx	Qmin	Qmáx	Qmin	Qmáx
Três Marias	**200**	**-**	**150**	**450**	**150**	**-**
Sobradinho	**800**	**-**	**800**	**-**	**800**	**-**
Luiz Gonzaga (Itaparica)	**1100**	**2000**	**800**	**1000**	**800**	**-**
Complexo P. Afonso / Moxotó	**1100**	**2000**	**800**	**1000**	**800**	**-**
Xingó	**1100**	**2000**	**800**	**1000**	**800**	**-**

O conteúdo desta publicação foi produzido pelo ONS com base em dados e informações de conhecimento público. É de responsabilidade exclusiva dos agentes e demais interessados a obtenção de outros dados e informações, a realização de análises, estudos e avaliações para fins de tomada de decisões, definição de estratégias de atuação, assunção de compromissos e obrigações e quaisquer outras finalidades, em qualquer tempo e sob qualquer condição. É proibida a reprodução ou utilização total ou parcial do presente sem a identificação da fonte.

3.3. Representação da Defluência das UHEs do Paranapanema

As restrições de defluências das UHEs do Paranapanema são definidas conforme Resolução ANA nº132/2022 de acordo com a figura abaixo.

Figura 5 – Restrições de defluências das UHEs do Paranapanema

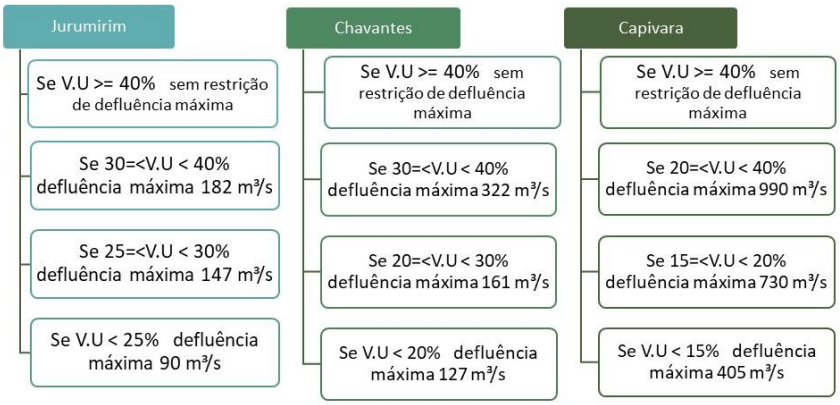

De acordo com a previsão do % do V.U da UHE Jurumirim é estabelecida a faixa na qual a usina se encontra. A partir da definição da faixa, foram emitidas as FSARH 6428/2024 a 6433/2024 representando a restrição de defluência máxima de 147 m³/s modelada no modelo Newave como restrição de geração máxima conforme tabela a seguir.

Tabela 3 – Defluência máxima da UHE Jurumirim

PMO Atual	
Restrição de Geração [MW]	
Cronograma	Jurumirim
ago/24	42,73
set/24	42,73

3.4. Restrição de escoamento das UHEs do Rio Madeira (UHE Santo Antônio e UHE Jirau)

A geração máxima da UHE Santo Antônio e UHE Jirau (Ger. MAD) é dada pela capacidade das usinas, da disponibilidade dos polos do Elo CC Madeira e back-to-back.
Assim, na modelagem energética, sem representação da rede de transmissão, esta restrição pode ser representada como:

- **Ger. MAD ≤ 6.300 + 700 + 417,6 (≤ 7.417,6 MW).**

Onde destaca-se que:

- 6.300 MW representa a capacidade em rede completa do Elo CC do Madeira;
- A capacidade do back-to-back é 800 MW, porém existem restrições na rede de 230 kV da região ACRO que não podem ser representadas no DECOMP. Para valores acima de 700 MW no back-to-back essas restrições limitariam a capacidade de exportação via rede

O conteúdo desta publicação foi produzido pelo ONS com base em dados e informações de conhecimento público. É de responsabilidade exclusiva dos agentes e demais interessados a obtenção de outros dados e informações, a realização de análises, estudos e avaliações para fins de tomada de decisões, definição de estratégias de atuação, assunção de compromissos e obrigações e quaisquer outras finalidades, em qualquer tempo e sob qualquer condição. É proibida a reprodução ou utilização total ou parcial do presente sem a identificação da fonte.

de 230 kV do ACRO e limitariam a geração das usinas deste sistema, notadamente UHE Samuel, Rondon II e Santo Antônio. Adicionalmente, para rede completa, o valor de 700 MW no fluxo do back-to-back é suficiente para escoar a geração completa do complexo do Madeira;

• 417,6 MW representa a geração disponível das unidades geradoras da UHE Santo Antônio conectadas no 230 kV.

Os valores de restrição adotados neste PMO constam na Tabela 4 a seguir:

Tabela 4 - Modelagem da restrição de escoamento do rio madeira associada às UHEs Santo Antônio e Jirau via geração hidráulica máxima em comparação com o PMO anterior

Restrição Geração [MW]			
UHEs	Cronograma	PMO jul/2024	PMO ago/2024
Santo Antônio e Jirau	1º e 2º mês	7.418,00 / 7.379,43 (jul e ago/24)	**7.379,43 / 7.410,44 (ago e set/24)**

(*) Representação conforme Nota Técnica de Limites de Curto Prazo, compatibilizada com o DECOMP

3.5. Demais Atualizações

Adicionalmente, neste PMO ocorreram os seguintes destaques:

- Horizonte de estudo: agosto de 2024 a dezembro de 2028;
- Cronograma de obras da Reunião DPME de 18/07/2024;
- CVUs das UTEs vendedoras em leilão;
- CVU da UTE NorteFluminense 1, 2, 3, 4 conforme Despacho ANEEL nº 2.042/2024;
- CVU das UTEs Termobahia, Juiz de Fora, Ibirité, Canoas, Nova Piratininga, Três Lagoas e Seropédica, conforme Despachos ANEEL nos 2.246/2023, 2.605/2023, 2.359/2023, 2.495/2023, 1.169/2024, 4.780/2023 e 4.861/2023, com atualização pela CCEE;
- Suspensão da OPC das UGs 1 e 2 da UHE Sobradinho conforme Despacho ANEEL nº 2.054/2024;
- Alteração da Potência das UGs da UTE Trombudo conforme o Despacho ANEEL nº 2.064/2024;
- Alteração de restrição operativa para a UHE Queimado, Xingó, Três Marias e A.A. Laydner de acordo com o FSARH enviado pelo Agente responsável;
- Limites de Intercâmbio mensais de curto prazo segundo Relatório Mensal de Limites de Intercâmbio RT-ONS DPL 0332/2024;
- Compatibilização da disponibilidade e inflexibilidade das usinas termoelétricas para os dois primeiros meses de acordo com informação da programação mensal;
- Compatibilização dos valores dos dois primeiros meses da geração hidráulica mínima das UHEs Itaipu e Tucuruí de acordo com os utilizados na programação mensal;
- Compatibilização dos estágios de deplecionamento das UHEs do Paraíba do Sul de acordo com informação da programação mensal;
- Previsões de carga consolidada para os dois primeiros meses.

O conteúdo desta publicação foi produzido pelo ONS com base em dados e informações de conhecimento público. É de responsabilidade exclusiva dos agentes e demais interessados a obtenção de outros dados e informações, a realização de análises, estudos e avaliações para fins de tomada de decisões, definição de estratégias de atuação, assunção de compromissos e obrigações e quaisquer outras finalidades, em qualquer tempo e sob qualquer condição. É proibida a reprodução ou utilização total ou parcial do presente sem a identificação da fonte.

4. INFORMAÇÕES CONJUNTURAIS PARA ELABORAÇÃO DO PMO

4.1. Informações hidrometeorológicas

4.1.1. Condições antecedentes

Na primeira quinzena de julho, a passagem de frentes frias e a atuação de áreas de instabilidade na Região Sul favoreceram a ocorrência de precipitação nas bacias hidrográficas dessa Região, sendo que os totais observados foram acima da média histórica nas bacias dos rios Iguaçu, Paranapanema e no trecho incremental a UHE Itaipu. As demais bacias hidrográficas de interesse do SIN apresentaram totais de precipitação inferiores à média histórica (Figura 6).

Figura 6 - Mapa de anomalia da precipitação acumulada (mm) – julho/2024

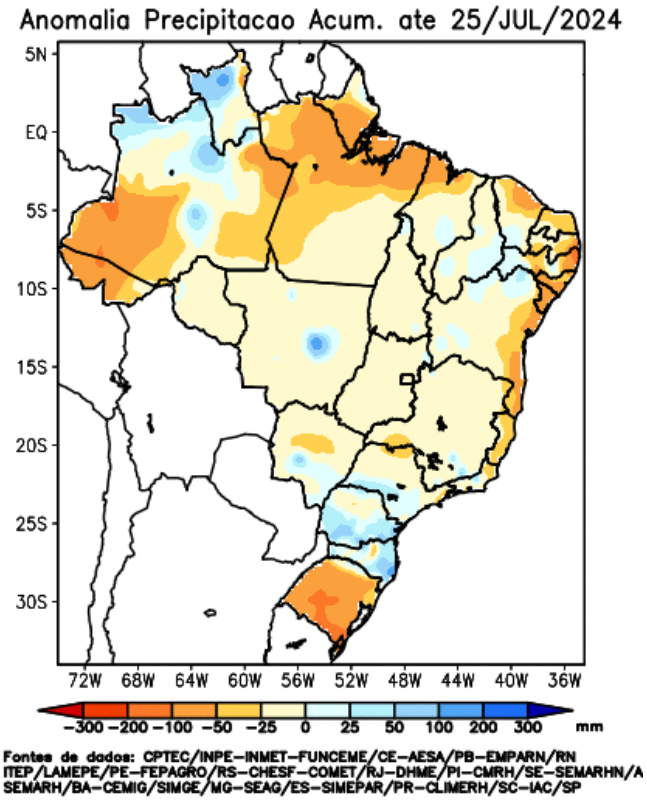

O conteúdo desta publicação foi produzido pelo ONS com base em dados e informações de conhecimento público. É de responsabilidade exclusiva dos agentes e demais interessados a obtenção de outros dados e informações, a realização de análises, estudos e avaliações para fins de tomada de decisões, definição de estratégias de atuação, assunção de compromissos e obrigações e quaisquer outras finalidades, em qualquer tempo e sob qualquer condição. É proibida a reprodução ou utilização total ou parcial do presente sem a identificação da fonte.

A atuação de uma massa de ar seco manteve a condição de céu claro e sem ocorrência de precipitação significativa nas principais bacias do SIN no decorrer da semana operativa (Figura 7).

Figura 7 - Precipitação observada (mm) no período de 20 a 24/07/2024

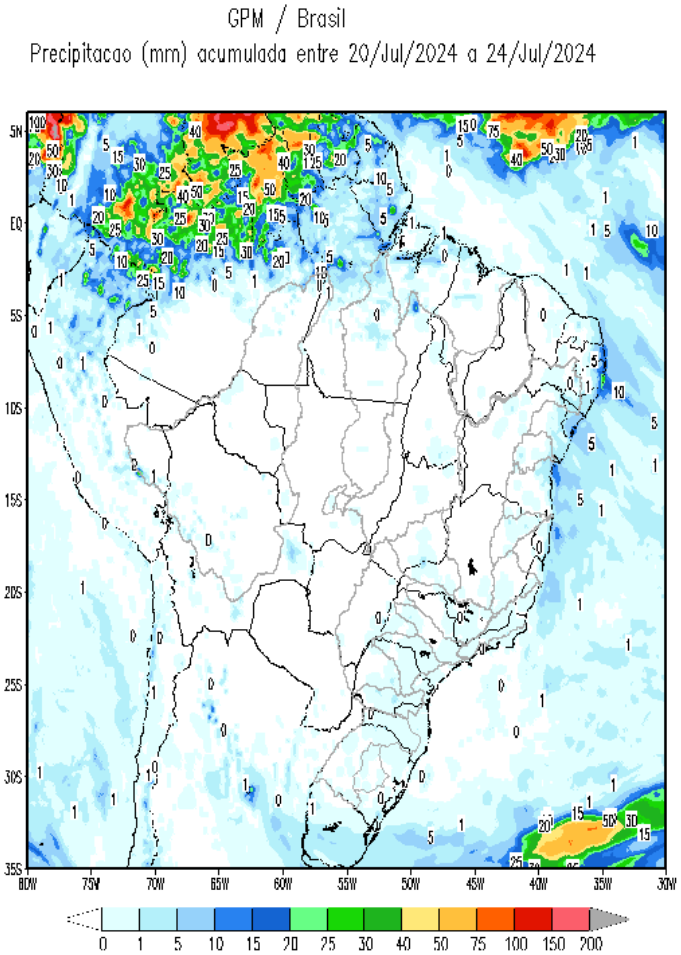

A **Tabela 5** apresenta as energias naturais afluentes das semanas recentes. São apresentados os valores verificados na semana 13/07/2024 a 19/07/2024 e os estimados para fechamento da semana de 20/07/2024 a 26/07/2024.

Tabela 5 – Tendência hidrológica da ENA do PMO de Agosto/2024

PMO de Agosto/2024 - ENAs verificadas e estimadas				
Subsistema	13/07 a 19/07/2024		20/07 a 26/07/2024	
	MWmed	%MLT	MWmed	%MLT
SE/CO	16.027	63	14.692	57
S	30.190	277	17.048	156
NE	1.610	43	1.480	39
N	2.704	51	2.360	45

O conteúdo desta publicação foi produzido pelo ONS com base em dados e informações de conhecimento público. É de responsabilidade exclusiva dos agentes e demais interessados a obtenção de outros dados e informações, a realização de análises, estudos e avaliações para fins de tomada de decisões, definição de estratégias de atuação, assunção de compromissos e obrigações e quaisquer outras finalidades, em qualquer tempo e sob qualquer condição. É proibida a reprodução ou utilização total ou parcial do presente sem a identificação da fonte.

4.1.2. Climatologia para o trimestre agosto-setembro-outubro de 2024

Para o trimestre agosto-setembro-outubro (ASO) de 2024, o cenário mais provável é de precipitação entre os tercis normal e abaixo da média histórica para as bacias hidrográficas localizadas na Região Sul. Climatologicamente, nesse trimestre os maiores totais de precipitação são observados no oeste da Região Norte e nas bacias hidrográficas da Região Sul (Figura 8).

Figura 8 - Climatologia de Precipitação para o trimestre agosto-setembro-outubro

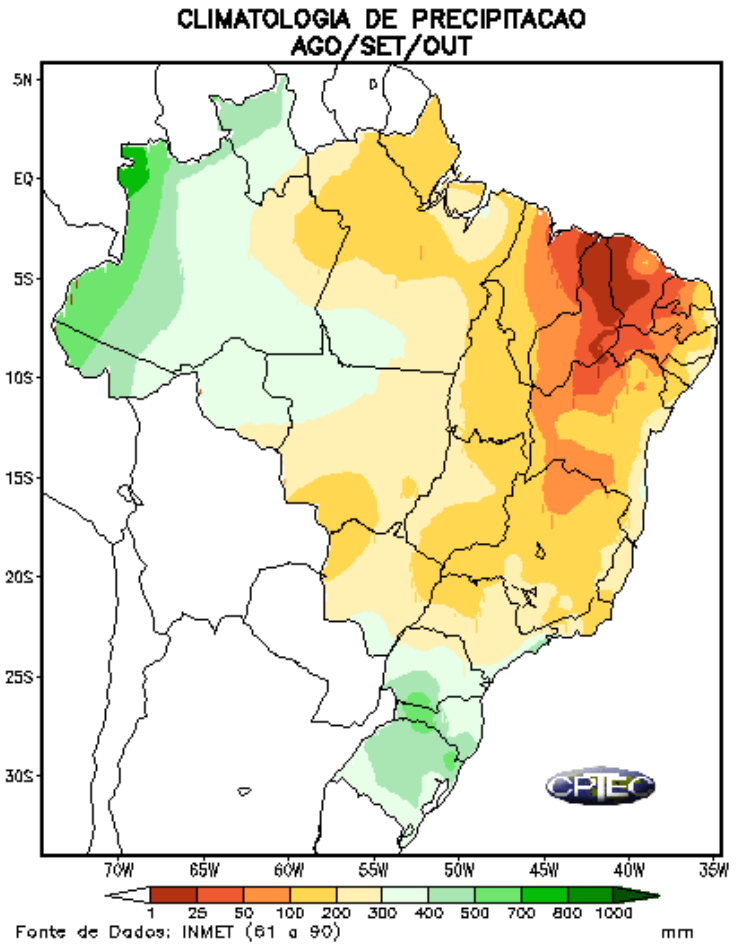

Fonte: Instituto Nacional de Meteorologia (INMET), período-base 1961-1990.

O conteúdo desta publicação foi produzido pelo ONS com base em dados e informações de conhecimento público. É de responsabilidade exclusiva dos agentes e demais interessados a obtenção de outros dados e informações, a realização de análises, estudos e avaliações para fins de tomada de decisões, definição de estratégias de atuação, assunção de compromissos e obrigações e quaisquer outras finalidades, em qualquer tempo e sob qualquer condição. É proibida a reprodução ou utilização total ou parcial do presente sem a identificação da fonte.

4.1.3. Previsão para a próxima semana

O avanço de uma frente fria no início da próxima semana ocasiona chuva fraca nas bacias dos rios Jacuí, Taquari-Antas, Uruguai, Iguaçu e em pontos isolados do Paranapanema e do trecho incremental a UHE Itaipu (Figura 9).

Figura 9 - Precipitação acumulada prevista pelo modelo ECMWF - período de 27/07 a 02/08/2024

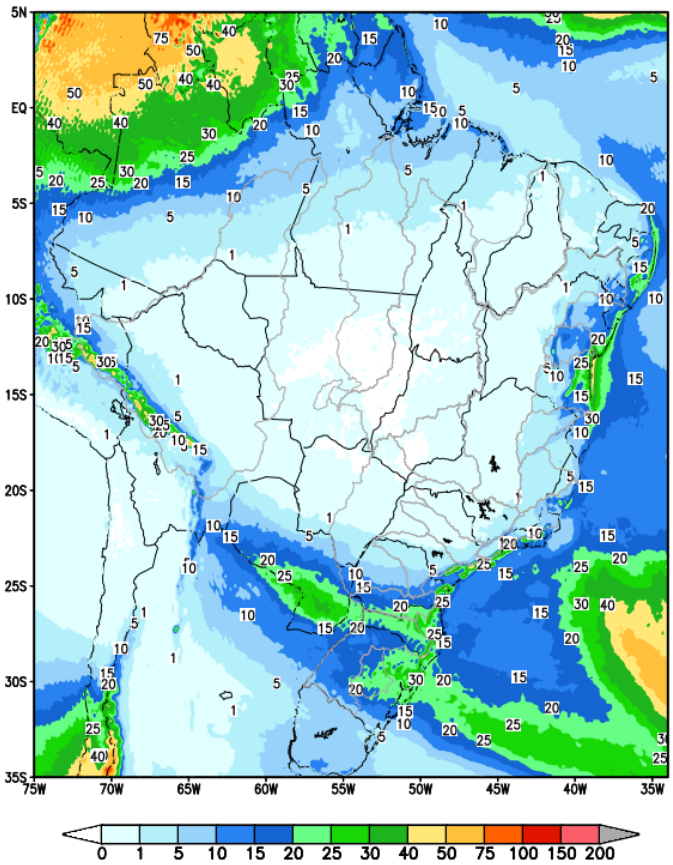

Em comparação com os valores estimados para a semana em curso, prevê-se para a próxima semana operativa recessão nas afluências dos subsistemas Sudeste/Centro-Oeste, Sul e Norte e estabilidade nas afluências do subsistema Nordeste. A previsão mensal para agosto indica a ocorrência de afluências abaixo da média histórica para todos os subsistemas.

Tabela 6 – Previsão de ENAs do PMO de Agosto/2024

PMO de Agosto/2024 - ENAs previstas				
Subsistema	27/07 a 02/08/2024		Mês de agosto	
	MWmed	%MLT	MWmed	%MLT
SE/CO	13.071	54	12.147	59
S	10.110	95	9.196	92
NE	1.482	41	1.374	42
N	2.006	43	1.589	50

O conteúdo desta publicação foi produzido pelo ONS com base em dados e informações de conhecimento público. É de responsabilidade exclusiva dos agentes e demais interessados a obtenção de outros dados e informações, a realização de análises, estudos e avaliações para fins de tomada de decisões, definição de estratégias de atuação, assunção de compromissos e obrigações e quaisquer outras finalidades, em qualquer tempo e sob qualquer condição. É proibida a reprodução ou utilização total ou parcial do presente sem a identificação da fonte.

As figuras a seguir ilustram as ENAs semanais previstas no PMO de Agosto/2024.

Figura 10 - Energias Naturais Afluentes ao Subsistema Sudeste/Centro-Oeste do PMO de Agosto/2024

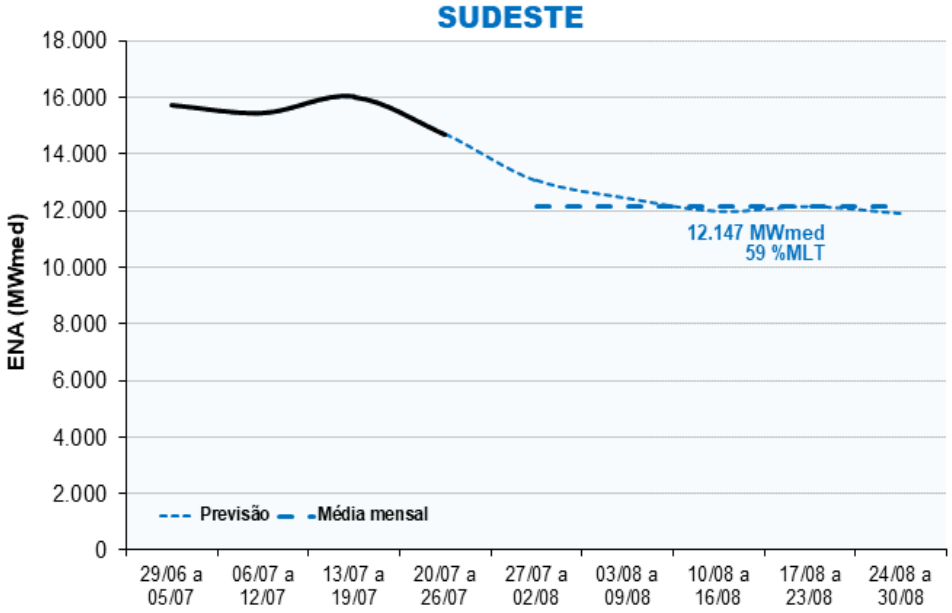

Figura 11 - Energias Naturais Afluentes ao Subsistema Sul do PMO de Agosto/2024

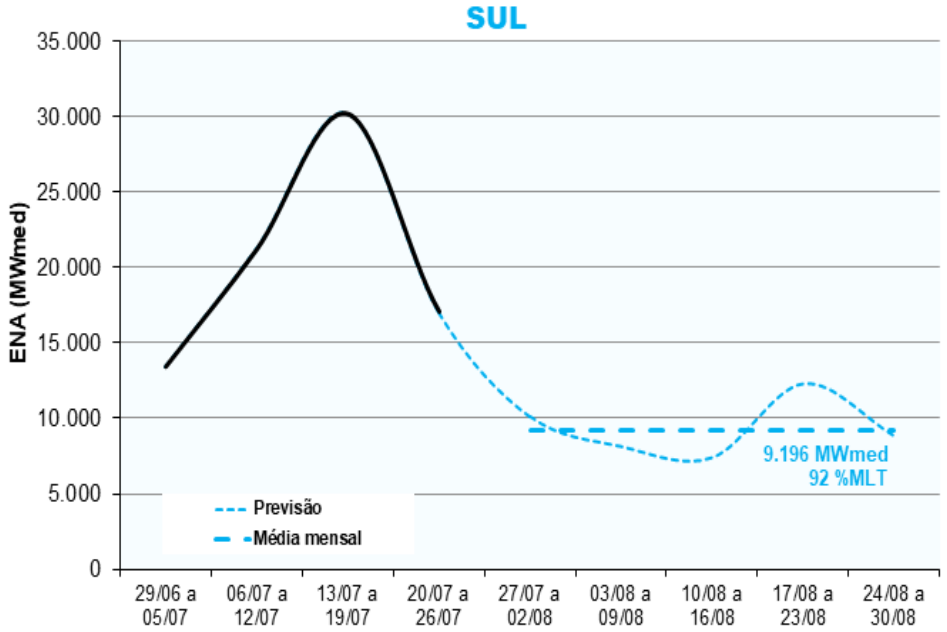

O conteúdo desta publicação foi produzido pelo ONS com base em dados e informações de conhecimento público. É de responsabilidade exclusiva dos agentes e demais interessados a obtenção de outros dados e informações, a realização de análises, estudos e avaliações para fins de tomada de decisões, definição de estratégias de atuação, assunção de compromissos e obrigações e quaisquer outras finalidades, em qualquer tempo e sob qualquer condição. É proibida a reprodução ou utilização total ou parcial do presente sem a identificação da fonte.

Figura 12 - Energias Naturais Afluentes ao Subsistema Nordeste do PMO de Agosto/2024

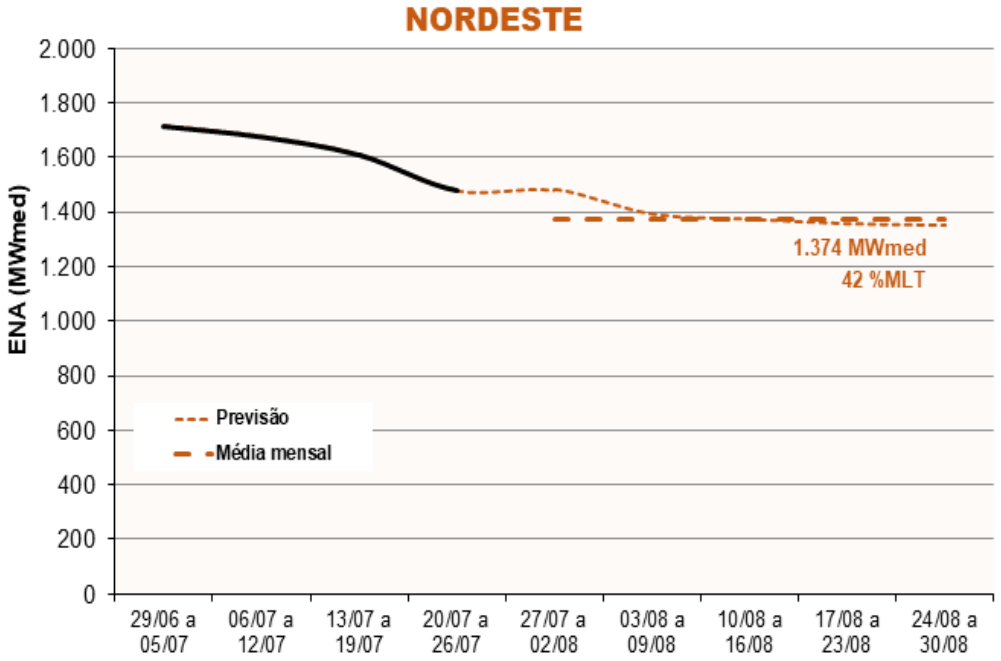

Figura 13 - Energias Naturais Afluentes ao Subsistema Norte do PMO de Agosto/2024

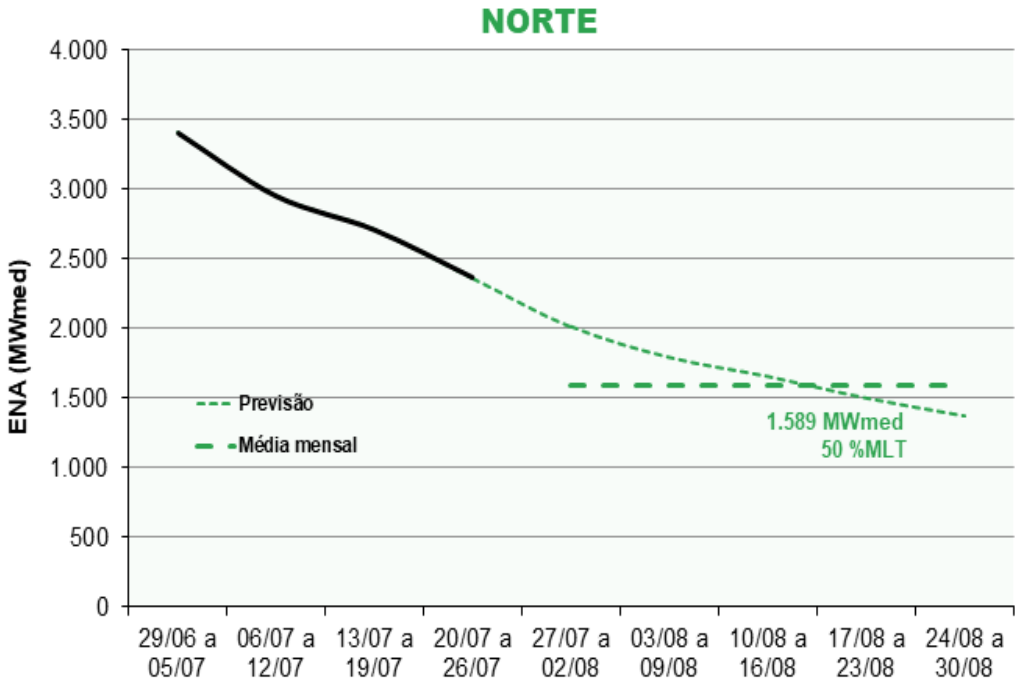

O conteúdo desta publicação foi produzido pelo ONS com base em dados e informações de conhecimento público. É de responsabilidade exclusiva dos agentes e demais interessados a obtenção de outros dados e informações, a realização de análises, estudos e avaliações para fins de tomada de decisões, definição de estratégias de atuação, assunção de compromissos e obrigações e quaisquer outras finalidades, em qualquer tempo e sob qualquer condição. É proibida a reprodução ou utilização total ou parcial do presente sem a identificação da fonte.

4.1.4. Cenários de ENAs para o PMO de Agosto/2024

As figuras a seguir apresentam as características dos cenários de energias naturais afluentes gerados no PMO de Agosto/2024, para acoplamento com a FCF do mês de setembro/2024. São mostradas, para os quatro subsistemas, as amplitudes e as Funções de Distribuição Acumulada dos cenários de ENA.

Figura 14 - Amplitude dos Cenários de ENA para o Subsistema Sudeste/Centro-Oeste, em %MLT, para o PMO de Agosto/2024

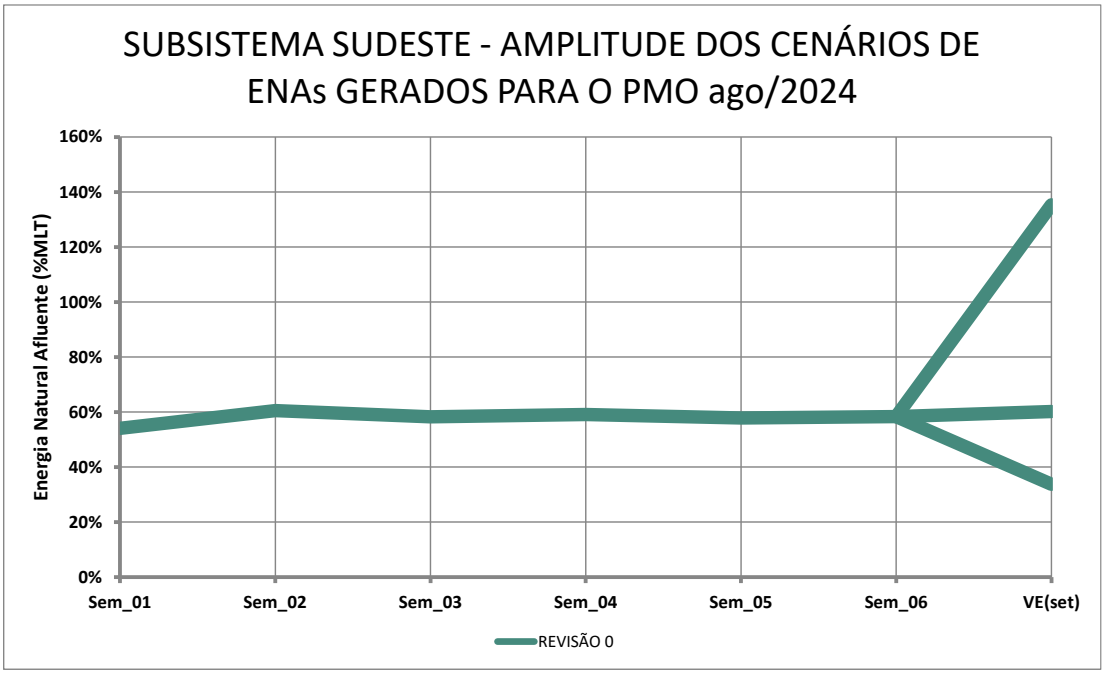

Figura 15 - Função de Distribuição Acumulada dos Cenários para o Subsistema Sudeste/Centro-Oeste para o PMO de Agosto/2024

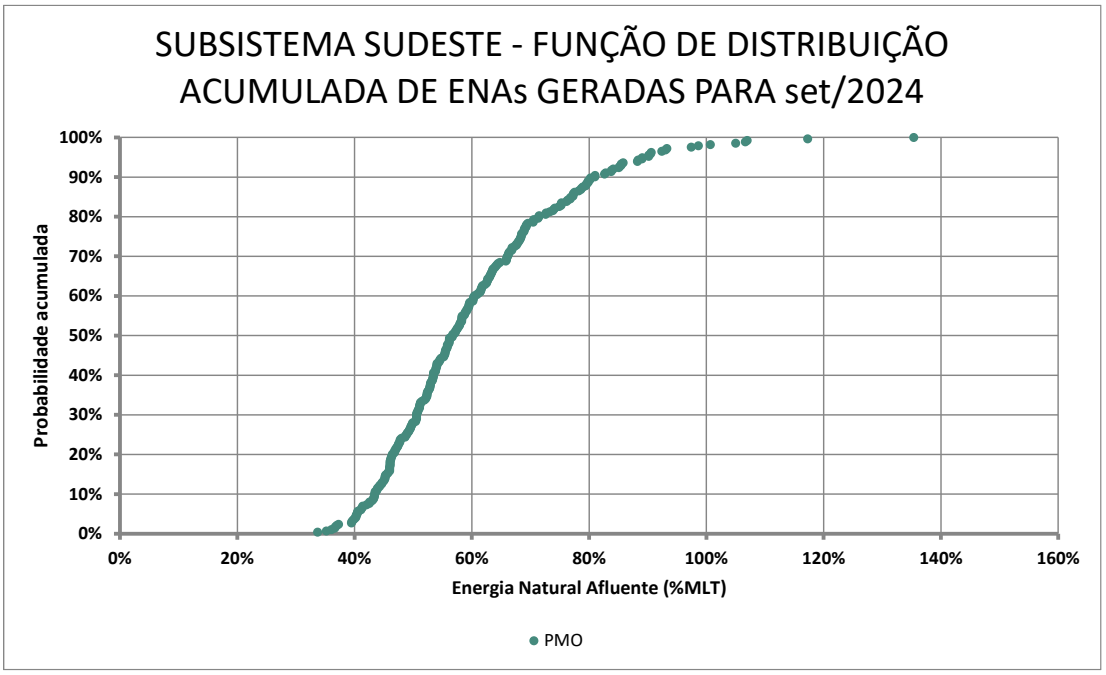

O conteúdo desta publicação foi produzido pelo ONS com base em dados e informações de conhecimento público. É de responsabilidade exclusiva dos agentes e demais interessados a obtenção de outros dados e informações, a realização de análises, estudos e avaliações para fins de tomada de decisões, definição de estratégias de atuação, assunção de compromissos e obrigações e quaisquer outras finalidades, em qualquer tempo e sob qualquer condição. É proibida a reprodução ou utilização total ou parcial do presente sem a identificação da fonte.

Figura 16 - Amplitude dos Cenários de ENA para o Subsistema Sul, em %MLT, para o PMO de Agosto/2024

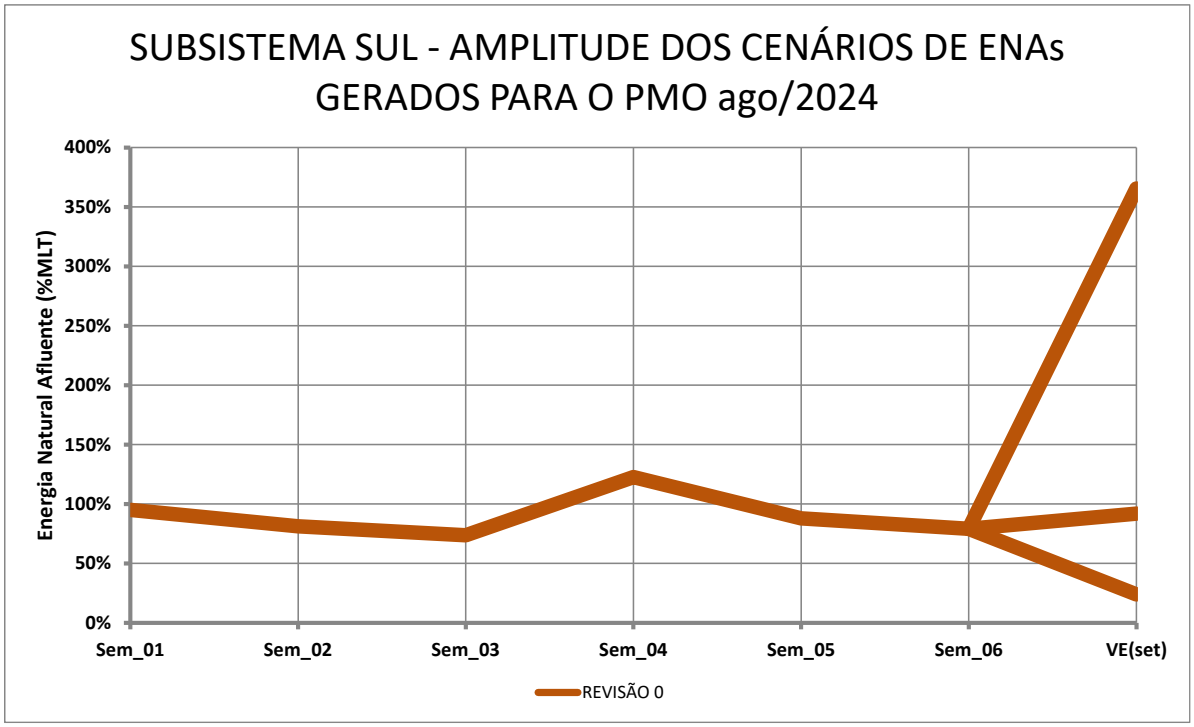

Figura 17 - Função de Distribuição Acumulada dos Cenários para o Subsistema Sul para o PMO de Agosto/2024

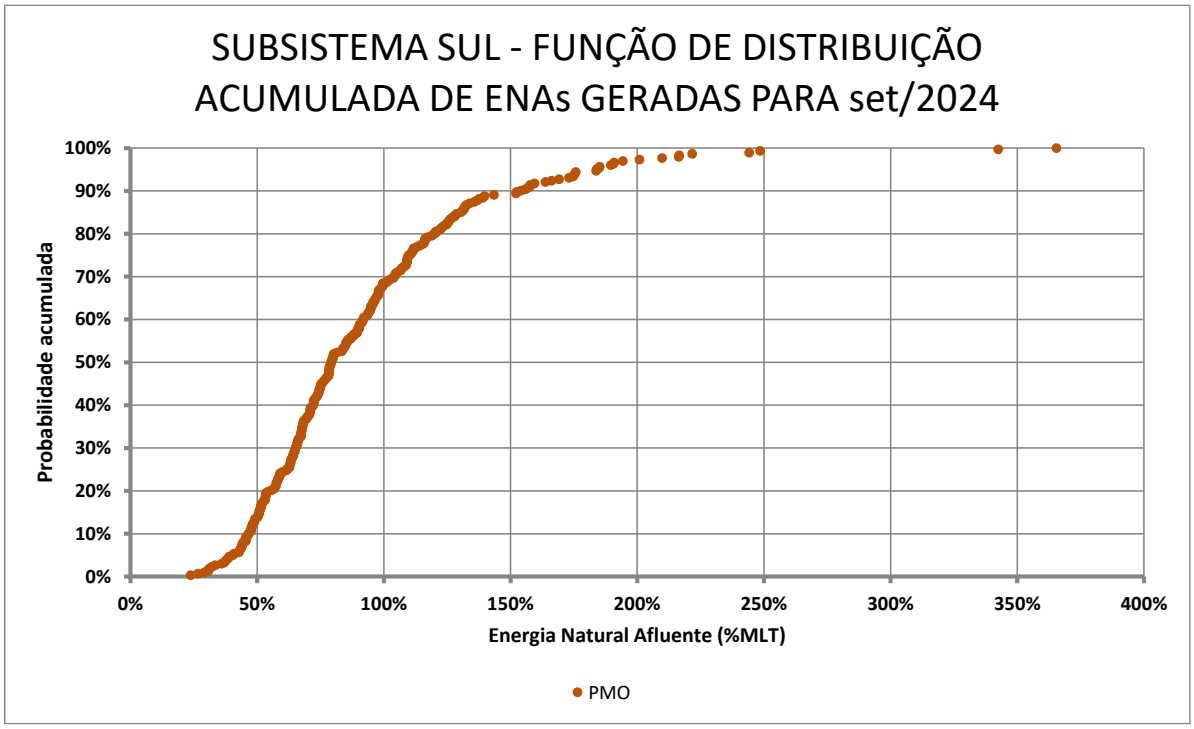

O conteúdo desta publicação foi produzido pelo ONS com base em dados e informações de conhecimento público. É de responsabilidade exclusiva dos agentes e demais interessados a obtenção de outros dados e informações, a realização de análises, estudos e avaliações para fins de tomada de decisões, definição de estratégias de atuação, assunção de compromissos e obrigações e quaisquer outras finalidades, em qualquer tempo e sob qualquer condição. É proibida a reprodução ou utilização total ou parcial do presente sem a identificação da fonte.

Figura 18 - Amplitude dos Cenários de ENA para o Subsistema Nordeste em %MLT, para o PMO de Agosto/2024

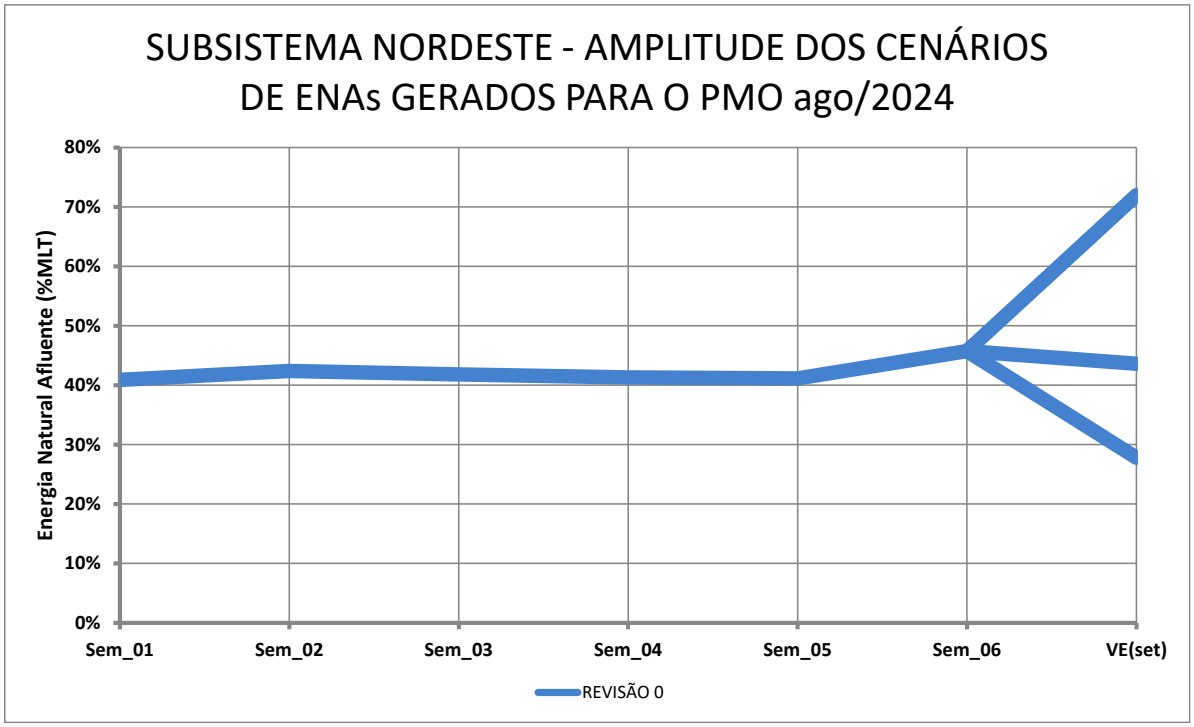

Figura 19 - Função de Distribuição Acumulada dos Cenários para o Subsistema Nordeste para o PMO de Agosto/2024

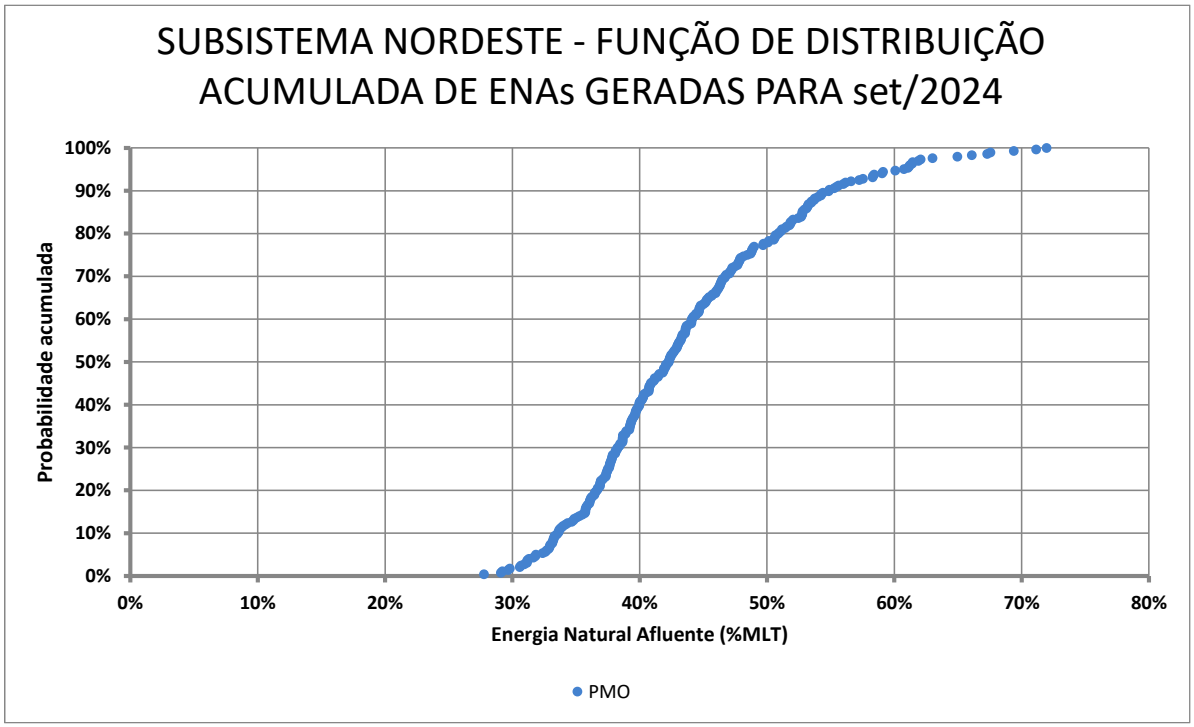

O conteúdo desta publicação foi produzido pelo ONS com base em dados e informações de conhecimento público. É de responsabilidade exclusiva dos agentes e demais interessados a obtenção de outros dados e informações, a realização de análises, estudos e avaliações para fins de tomada de decisões, definição de estratégias de atuação, assunção de compromissos e obrigações e quaisquer outras finalidades, em qualquer tempo e sob qualquer condição. É proibida a reprodução ou utilização total ou parcial do presente sem a identificação da fonte.

Figura 20 - Amplitude dos Cenários de ENA para o Subsistema Norte, em %MLT, para o PMO de Agosto/2024

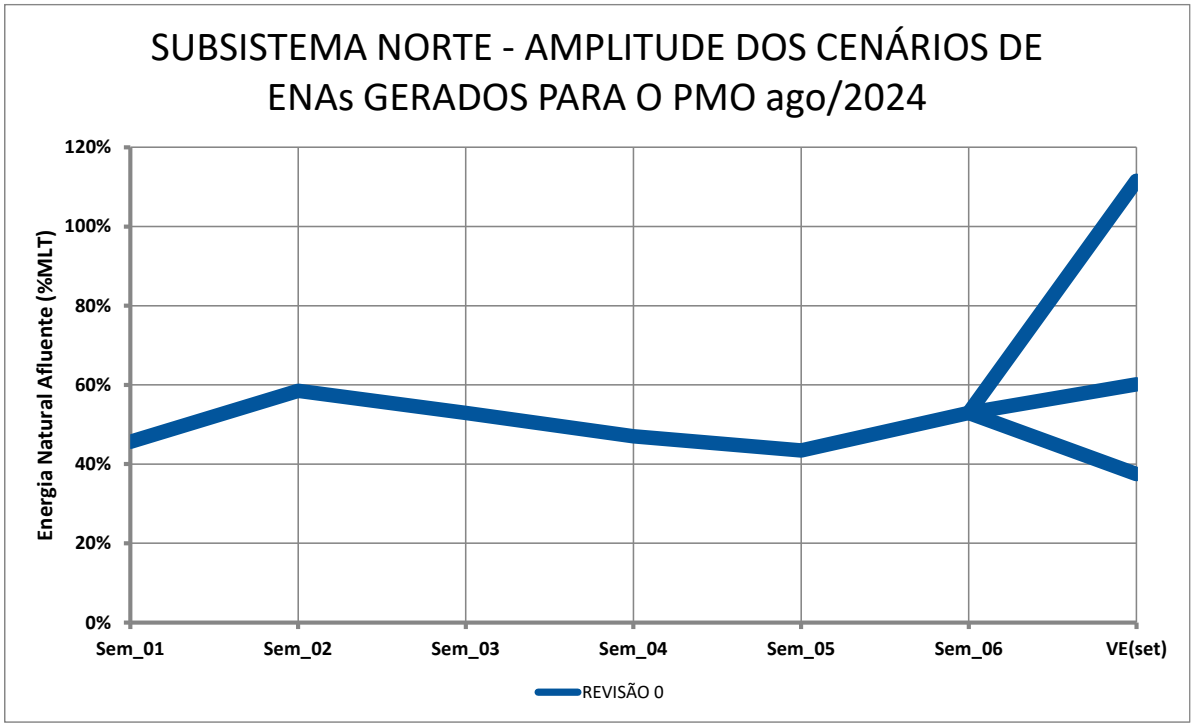

Figura 21 - Função de Distribuição Acumulada dos Cenários para o Subsistema Norte para o PMO de Agosto/2024

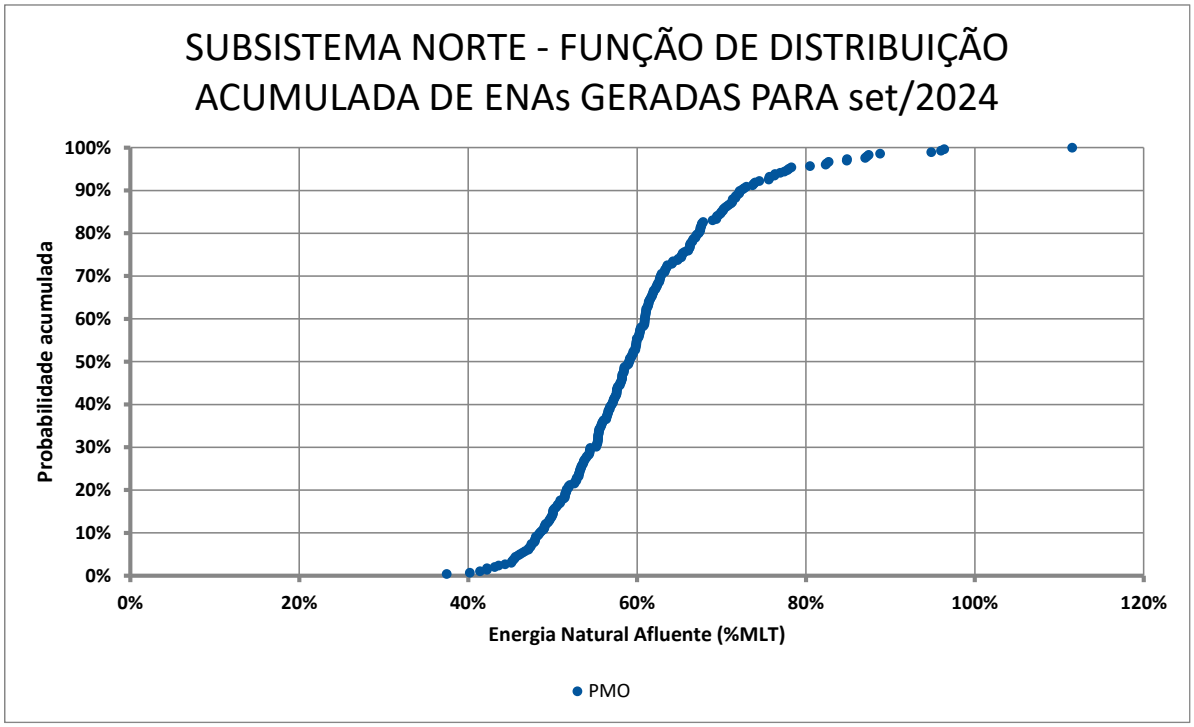

O conteúdo desta publicação foi produzido pelo ONS com base em dados e informações de conhecimento público. É de responsabilidade exclusiva dos agentes e demais interessados a obtenção de outros dados e informações, a realização de análises, estudos e avaliações para fins de tomada de decisões, definição de estratégias de atuação, assunção de compromissos e obrigações e quaisquer outras finalidades, em qualquer tempo e sob qualquer condição. É proibida a reprodução ou utilização total ou parcial do presente sem a identificação da fonte.

Os valores da MLT (Média de Longo Termo) das energias naturais afluentes para os meses de agosto/2024 e setembro/2024 são apresentados na tabela a seguir.

Tabela 7 – MLT da ENA nos meses de agosto/2024 e setembro/2024

MLT das ENAs (MWmed)		
Subsistema	agosto	setembro
SE/CO	20.521	19.627
S	10.004	11.628
NE	3.279	2.933
N	3.184	2.267

4.2. Limites de Intercâmbio entre Subsistemas

Os limites elétricos de intercâmbio de energia entre subsistemas são de fundamental importância para o processo de otimização energética, sendo determinantes para a definição das políticas de operação e do CMO para cada subsistema. Estes limites são influenciados por intervenções na malha de transmissão, notadamente na primeira semana operativa. O diagrama a seguir ilustra os fluxos notáveis do SIN e os limites aplicados neste PMO.

Figura 22 – Interligações entre regiões

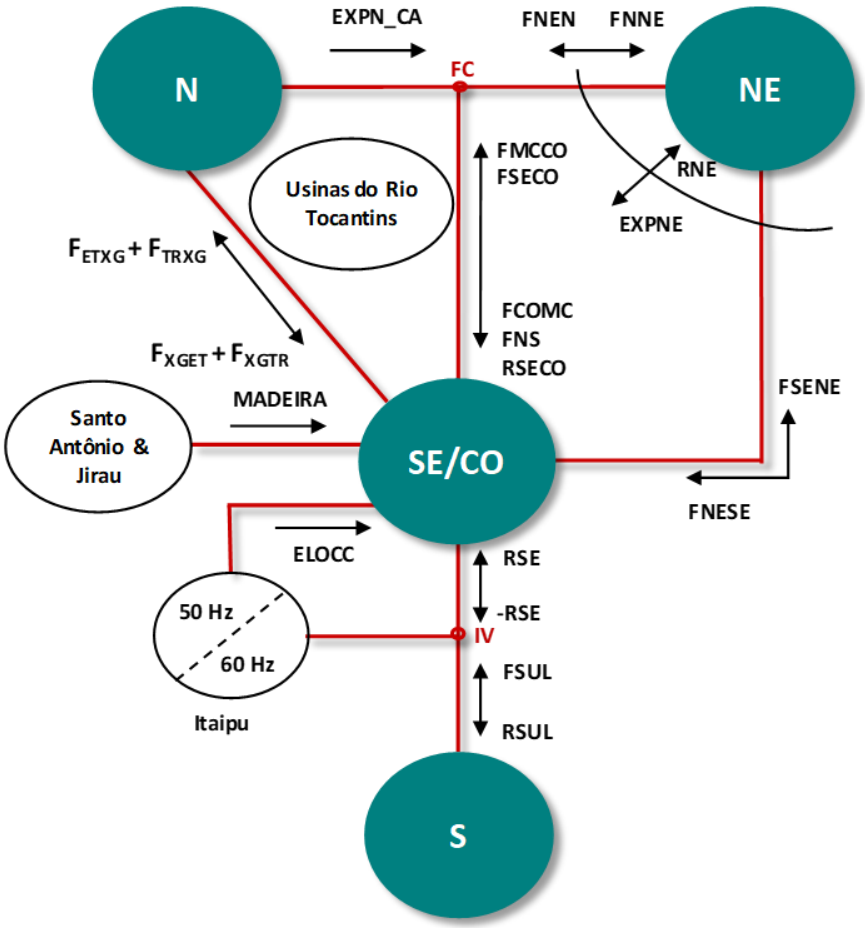

O conteúdo desta publicação foi produzido pelo ONS com base em dados e informações de conhecimento público. É de responsabilidade exclusiva dos agentes e demais interessados a obtenção de outros dados e informações, a realização de análises, estudos e avaliações para fins de tomada de decisões, definição de estratégias de atuação, assunção de compromissos e obrigações e quaisquer outras finalidades, em qualquer tempo e sob qualquer condição. É proibida a reprodução ou utilização total ou parcial do presente sem a identificação da fonte.

Tabela 8 – Limites considerados nesta semana operativa para intercâmbio de energia

Limites de Intercâmbio (MWmed)				
Fluxo	Patamar	27/07 a 02/08/2024		Demais Semanas
RNE	Pesada	11.000		11.000
	Média	11.000		11.000
	Leve	11.000		11.000
FNS	Pesada	**4.900**	(A) (B) (C) (D) (E) (F)	5.100
	Média	**4.776**		5.100
	Leve	**3.869**		4.900
FNNE	Pesada	4.800		4.800
	Média	**4.791**	(G)	4.800
	Leve	**4.756**		4.800
EXPORT. NE	Pesada	11.600		11.600
	Média	11.600		11.600
	Leve	11.600		11.600
FMCCO	Pesada	5.000		5.000
	Média	**4.953**	(A)	5.000
	Leve	**4.764**		5.000
FSENE	Pesada	6.000		6.000
	Média	6.000		6.000
	Leve	6.000		6.000
FNS + FNESE	Pesada	**10.900**	(A) (B) (C) (F)	11.100
	Média	**10.886**		11.100
	Leve	**10.856**		11.100
RSE	Pesada	**7.717**		9.800
	Média	**7.386**	(H)	9.800
	Leve	**9.500**		10.800
FORNEC. SUL	Pesada	7.000		7.000
	Média	7.000		7.000
	Leve	8.600		8.600

Limites de Intercâmbio (MWmed)				
Fluxo	Patamar	27/07 a 02/08/2024		Demais Semanas
RECEB. SUL	Pesada	**9.183**	(H)	9.600
	Média	**7.317**		7.800
	Leve	**7.400**		7.900
ELO CC 50 Hz	Pesada	**3.000**	(I)	5.481
	Média	**3.342**		5.481
	Leve	**4.458**		5.481
ITAIPU 60 Hz	Pesada	7.500		7.500
	Média	7.500		7.500
	Leve	7.500		7.500
EXP. N CA	Pesada	8.000		8.000
	Média	8.000		8.000
	Leve	8.000		8.000
FETXG + FTRXG	Pesada	4.200		4.200
	Média	2.500		2.500
	Leve	2.500		2.500
FXGET + FXGTR	Pesada	3.000		3.000
	Média	3.000		3.000
	Leve	3.000		3.000
FNESE	Pesada	8.300	(A) (C) (D) (E) (G) (J) (K)	8.300
	Média	**8.003**		8.300
	Leve	**6.421**		8.300
FNEN	Pesada	4.800		4.800
	Média	**4.791**	(G)	4.800
	Leve	**4.756**		4.800
Ger_MADEIRA	Pesada	**7.218**	(L) (M) (N)	7.348
	Média	**7.157**		7.348
	Leve	**7.087**		7.348

(A)	SGI 40.289-24
(B)	SGI 40.334-24
(C)	SGI 41.247-24
(D)	SGI 42.284-24
(E)	SGI 37.245-24
(F)	SGI 27.213-24
(G)	SGI 40.300-24
(H)	SGI 33.188-24
(I)	SGI 41.828-24
(J)	SGI 42.045-24
(K)	SGI 39.175-24
(L)	SGI 38.958-24
(M)	SGI 36.751-24
(N)	SGI 38.793-24

O conteúdo desta publicação foi produzido pelo ONS com base em dados e informações de conhecimento público. É de responsabilidade exclusiva dos agentes e demais interessados a obtenção de outros dados e informações, a realização de análises, estudos e avaliações para fins de tomada de decisões, definição de estratégias de atuação, assunção de compromissos e obrigações e quaisquer outras finalidades, em qualquer tempo e sob qualquer condição. É proibida a reprodução ou utilização total ou parcial do presente sem a identificação da fonte.

4.3. Previsão de carga

Em julho, o Índice de Confiança do Consumidor (ICC) e o índice de Confiança da Construção (ICST) avançaram 1,8 pontos e 0,9 pontos, atingindo 92,9 pontos e 97,3 pontos, respectivamente. A alta do ICC, este mês, está alicerçada na alta das expectativas visto que o índice de situação atual se manteve estável. Apesar da alta estar disseminada entre três das quatro faixas de renda pesquisadas, as menores faixas são as que mais impulsionam o resultado. Para a FGV, o resultado do índice encontra-se alinhado com a situação de maior controle inflacionário e mercado de trabalho mais aquecido. Também o crescimento do ICST foi influenciado pelo resultado do índice de expectativas, o que segundo a FGV, indica que o setor se mantém aquecido e acreditando na manutenção do atual ciclo de crescimento econômico. Com relação a inflação, a IPCA-15 de julho desacelerou com relação a junho, avançando 0,30% e acumulando alta de 2,28% no ano e 4,45% em 12 meses. A maior variação de preços foi observada nos itens transporte e habitação.

Nos subsistemas Sudeste/Centro-Oeste e Sul, na semana operativa em curso, houve elevação gradativa e lenta das temperaturas, resultando em aumento nas temperaturas médias no Rio de Janeiro, São Paulo, Cuiabá, Campo Grande e nas capitais da região Sul. Para o próximo período, a sinalização é de entrada de frente fria no início da semana operativa ocasionada por uma massa de ar frio, iniciando Porto Alegre e avançando para as demais capitais da região Sul, Sudeste e Centro-Oeste. Espera-se que a passagem de frente fria provoque precipitação e declínio das temperaturas, com posterior elevação ao final da semana operativa, ocasionando queda nas temperaturas máximas nas capitais da região Sul e em São Paulo. Nas demais capitais das regiões Sudeste e Centro-Oeste as temperaturas extremas se mantêm estáveis. São esperados aumentos nos acumulados de precipitação em Porto Alegre, Curitiba e São Paulo e estabilidade nas demais capitais.

As temperaturas e totais de precipitação observados nas capitais dos estados que compõem os subsistemas Nordeste e Norte devem se manter estáveis com relação a semana em curso e ao comportamento típico para essa época do ano. Há indicação de chuva diária, sem grande intensidade e intermitente, na próxima semana operativa, em Salvador e Recife.

Assim, os novos valores de carga previstos para o mês de agosto/2024, indicam taxas de crescimento de 1,1% no subsistema Sudeste/Centro-Oeste, 5,6% no subsistema Sul, 5,8% no subsistema Nordeste e 7,1% no subsistema Norte.

Tabela 9 – Evolução da carga do PMO de Agosto de 2024

Subsistema	CARGA SEMANAL (MWmed)						CARGA MENSAL (MWmed)	
	1ª Sem	2ª Sem	3ª Sem	4ª Sem	5ª Sem	6ª Sem	ago/24	Var. (%) ago/24 -> ago/23
SE/CO	40.733	41.430	42.073	42.200	42.204	42.378	41.909	1,1%
Sul	12.781	12.964	12.971	12.989	12.991	12.912	12.964	5,6%
Nordeste	12.381	12.483	12.528	12.543	12.527	12.555	12.512	5,8%
Norte	7.820	7.917	8.006	8.138	8.178	8.144	8.047	7,1%
SIN	**73.715**	**74.794**	**75.577**	**75.870**	**75.900**	**75.989**	**75.432**	**3,2%**

O conteúdo desta publicação foi produzido pelo ONS com base em dados e informações de conhecimento público. É de responsabilidade exclusiva dos agentes e demais interessados a obtenção de outros dados e informações, a realização de análises, estudos e avaliações para fins de tomada de decisões, definição de estratégias de atuação, assunção de compromissos e obrigações e quaisquer outras finalidades, em qualquer tempo e sob qualquer condição. É proibida a reprodução ou utilização total ou parcial do presente sem a identificação da fonte.

4.4. Potência Hidráulica Total Disponível no SIN

O gráfico a seguir mostra a disponibilidade hidráulica total do SIN, para este mês, de acordo com o cronograma de manutenção informado pelos agentes para este PMO.

Figura 23 – Potência hidráulica disponível no SIN

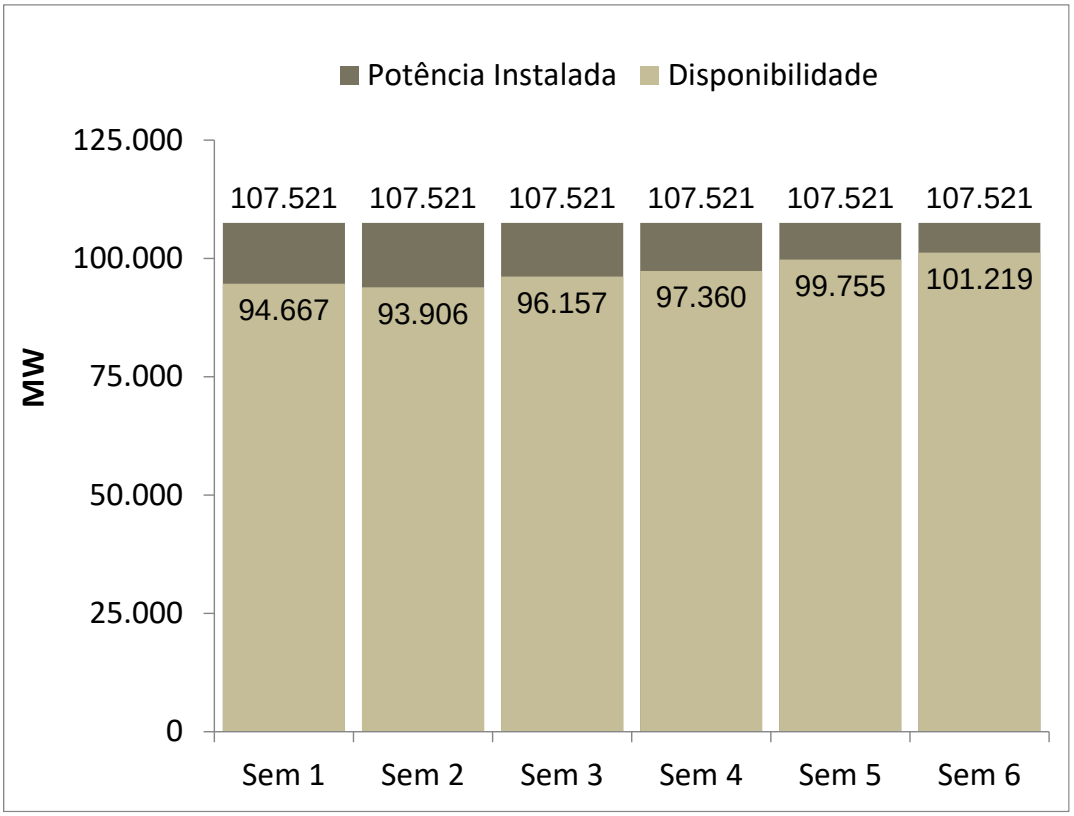

4.5. Armazenamentos Iniciais por Subsistema

Tabela 10 – Armazenamentos iniciais, por subsistema, considerados para esta semana operativa

Armazenamento (%EARmáx) - 0:00 h do dia 27/07/2024		
Subsistema	**Nível previsto na Revisão 3 do PMO Jul/2024**	**Partida informada pelos Agentes para o PMO Ago/2024**
SE/CO	63,0	63,2
S	90,4	90,7
NE	64,1	63,9
N	87,2	85,7

A primeira coluna da tabela acima corresponde ao armazenamento previsto na Revisão 3 do PMO de Julho de 2024, para a 0:00 h do dia 27/07/2024. A segunda coluna apresenta os armazenamentos obtidos a partir dos níveis de partida informados pelos Agentes de Geração para seus aproveitamentos com reservatórios.

O conteúdo desta publicação foi produzido pelo ONS com base em dados e informações de conhecimento público. É de responsabilidade exclusiva dos agentes e demais interessados a obtenção de outros dados e informações, a realização de análises, estudos e avaliações para fins de tomada de decisões, definição de estratégias de atuação, assunção de compromissos e obrigações e quaisquer outras finalidades, em qualquer tempo e sob qualquer condição. É proibida a reprodução ou utilização total ou parcial do presente sem a identificação da fonte.

5. PRINCIPAIS RESULTADOS

5.1. Política de Operação Energética

Para esta semana operativa, está prevista a seguinte política de intercâmbio de energia entre regiões:

Região SE/CO:

- Geração dimensionada para controle de nível e atendimento a carga pesada e Folga de Potência Monitorada nas usinas do Grande e Paranaíba.

- Adoção da política operativa de operação na defluência mínima na UHE Porto Primavera com vistas a preservação dos reservatórios da Bacia do Paraná;

Região Sul:

- Geração maximizada em todos os patamares de carga quando possível;

Região NE:

- Geração dimensionada para maximização da exportação de energia para o SE;

Região Norte:

- Alocação da geração disponível e monitoração das afluências. UHE Tucuruí alocada no FPM seguindo a curva de deplecionamento.

5.2. Custo Marginal de Operação – CMO

A figura a seguir apresenta os Custos Marginais de Operação, em valores médios semanais, para as semanas operativas deste mês.

Figura 24 – CMO em valores médios

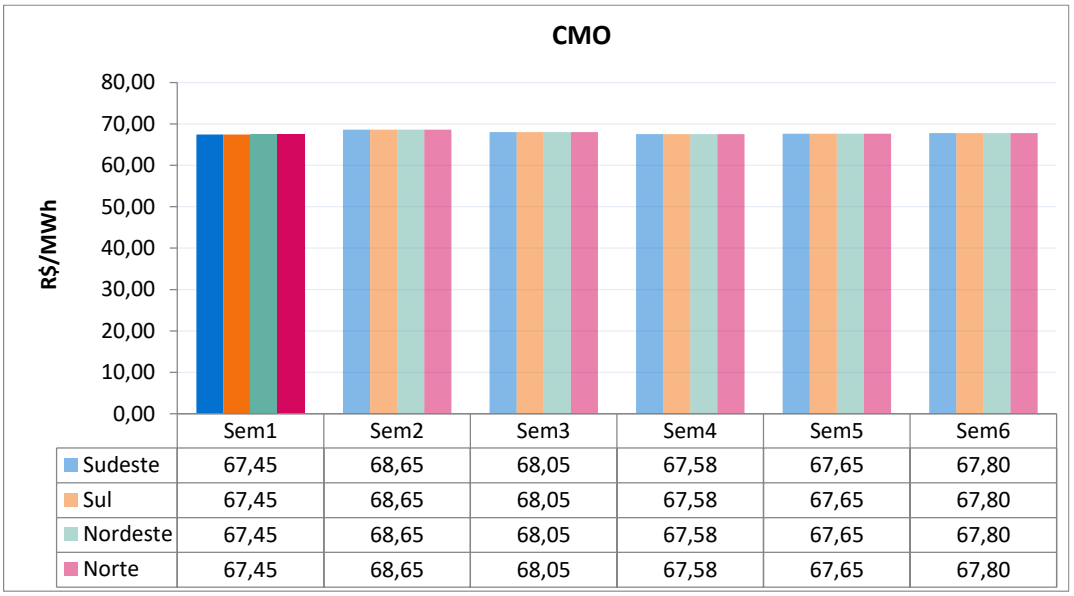

	Sem1	Sem2	Sem3	Sem4	Sem5	Sem6
Sudeste	67,45	68,65	68,05	67,58	67,65	67,80
Sul	67,45	68,65	68,05	67,58	67,65	67,80
Nordeste	67,45	68,65	68,05	67,58	67,65	67,80
Norte	67,45	68,65	68,05	67,58	67,65	67,80

O conteúdo desta publicação foi produzido pelo ONS com base em dados e informações de conhecimento público. É de responsabilidade exclusiva dos agentes e demais interessados a obtenção de outros dados e informações, a realização de análises, estudos e avaliações para fins de tomada de decisões, definição de estratégias de atuação, assunção de compromissos e obrigações e quaisquer outras finalidades, em qualquer tempo e sob qualquer condição. É proibida a reprodução ou utilização total ou parcial do presente sem a identificação da fonte.

A tabela a seguir apresenta o custo marginal de operação, por subsistema e patamar de carga, para a próxima semana operativa.

Tabela 11 – CMO para esta semana operativa

Patamares de Carga	CMO (R$/MWh)			
	SE/CO	S	NE	N
Pesada	69,40	69,40	69,40	69,40
Média	67,47	67,47	67,47	67,47
Leve	66,70	66,70	66,70	66,70
Média Semanal	67,45	67,45	67,45	67,45

5.3. Energia armazenada

O processo de otimização realizado pelo programa DECOMP indicou os armazenamentos mostrados na figura a seguir para as próximas semanas operativas do mês de agosto/2024.

Figura 25 – Energias Armazenadas nas semanas operativas do mês de agosto/2024.

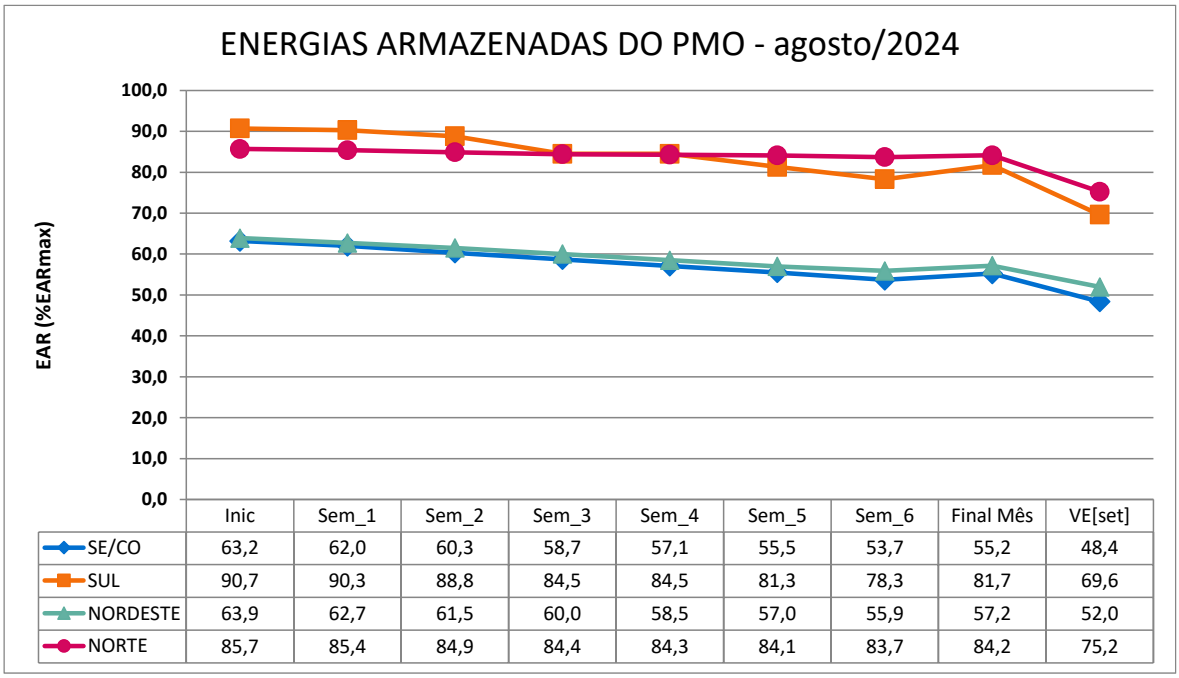

	Inic	Sem_1	Sem_2	Sem_3	Sem_4	Sem_5	Sem_6	Final Mês	VE[set]
SE/CO	63,2	62,0	60,3	58,7	57,1	55,5	53,7	55,2	48,4
SUL	90,7	90,3	88,8	84,5	84,5	81,3	78,3	81,7	69,6
NORDESTE	63,9	62,7	61,5	60,0	58,5	57,0	55,9	57,2	52,0
NORTE	85,7	85,4	84,9	84,4	84,3	84,1	83,7	84,2	75,2

Os armazenamentos da figura anterior estão expressos em percentual da Energia Armazenável Máxima de cada subsistema, que são mostradas na tabela a seguir.

Tabela 12 – Energia Armazenável Máxima por subsistema no PMO de Agosto/2024.

ENERGIA ARMAZENÁVEL MÁXIMA (MWmed)		
Subsistema	Agosto	Setembro
SE/CO	205.460	205.460
S	20.458	20.458
NE	51.718	51.718
N	15.689	15.711

O conteúdo desta publicação foi produzido pelo ONS com base em dados e informações de conhecimento público. É de responsabilidade exclusiva dos agentes e demais interessados a obtenção de outros dados e informações, a realização de análises, estudos e avaliações para fins de tomada de decisões, definição de estratégias de atuação, assunção de compromissos e obrigações e quaisquer outras finalidades, em qualquer tempo e sob qualquer condição. É proibida a reprodução ou utilização total ou parcial do presente sem a identificação da fonte.

6. GERAÇÃO TÉRMICA

A Figura 26 apresenta, para cada subsistema do SIN, o despacho térmico por modalidade indicado pelo Decomp para esta semana operativa.

Figura 26 – Geração térmica para a próxima semana operativa

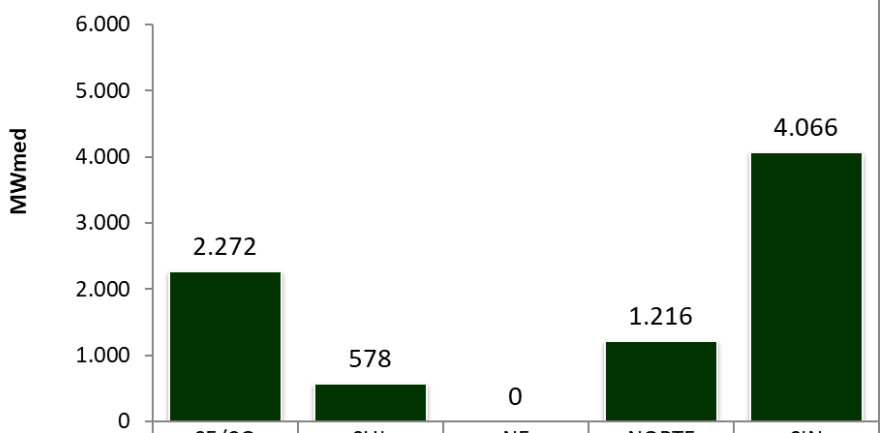

	SE/CO	SUL	NE	NORTE	SIN
TOTAL	2.272	578	0	1.216	4.066
RESTRIÇÃO ELÉTRICA	0	0	0	0	0
INFLEXIBILIDADE	2272	578	0	1216	4066
ORDEM DE MÉRITO	0	0	0	0	0

Na tabela abaixo segue a Indicação de despacho antecipado por ordem de mérito de custo para a semana de 28/09/2024 a 04/10/2024.

Tabela 13 – UTEs com contrato de combustível GNL

UTE			Benefício (R$/MWh)		
Nome	Cod	CVU (R$/MWh)	Carga Pesada	Carga Média	Carga Leve
SANTA CRUZ	86	182,65	64,39 (2)	64,39 (2)	64,35 (2)
LUIZORMELO	15	273,27	64,39 (2)	64,39 (2)	64,35 (2)
PSERGIPE I	224	372,64	64,39 (2)	64,39 (2)	64,35 (2)

(1) Comandado o despacho antecipado por ordem de mérito de custo nesse patamar
(2) NÃO foi comandado o despacho antecipado por ordem de mérito de custo nesse patamar

Assim sendo, não há previsão de despacho antecipado por ordem de mérito de custo para as UTE Santa Cruz, Luiz O. R. Melo e Porto Sergipe I, para a semana de 28/09/2024 a 04/10/2024.

O conteúdo desta publicação foi produzido pelo ONS com base em dados e informações de conhecimento público. É de responsabilidade exclusiva dos agentes e demais interessados a obtenção de outros dados e informações, a realização de análises, estudos e avaliações para fins de tomada de decisões, definição de estratégias de atuação, assunção de compromissos e obrigações e quaisquer outras finalidades, em qualquer tempo e sob qualquer condição. É proibida a reprodução ou utilização total ou parcial do presente sem a identificação da fonte.

O gráfico a seguir apresenta, em atendimento à Portaria Normativa nº 62/GM/MME, de 30 de março de 2023, a expectativa de despacho Térmico para os dois meses do horizonte de estudo.

Figura 27 – Expectativa de despacho térmico para o horizonte de dois meses

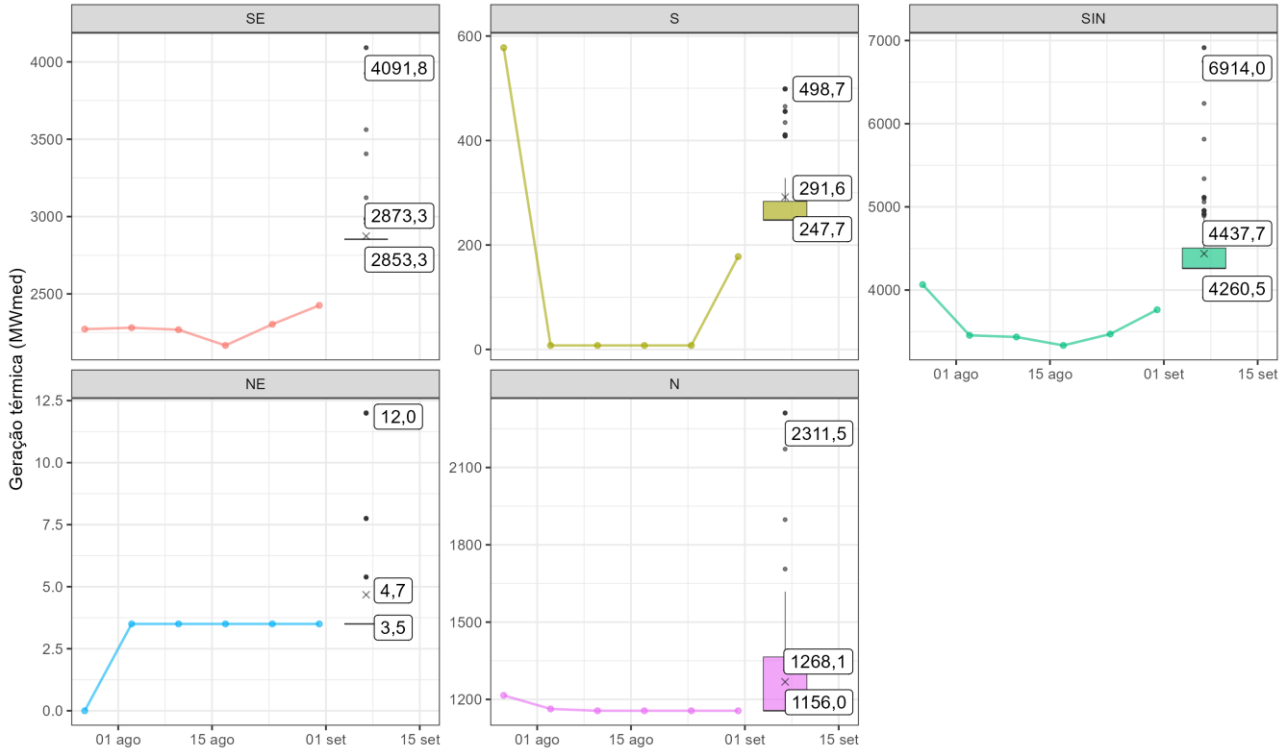

O conteúdo desta publicação foi produzido pelo ONS com base em dados e informações de conhecimento público. É de responsabilidade exclusiva dos agentes e demais interessados a obtenção de outros dados e informações, a realização de análises, estudos e avaliações para fins de tomada de decisões, definição de estratégias de atuação, assunção de compromissos e obrigações e quaisquer outras finalidades, em qualquer tempo e sob qualquer condição. É proibida a reprodução ou utilização total ou parcial do presente sem a identificação da fonte.

7. IMPORTAÇÃO DE ENERGIA

7.1. República Oriental do Uruguai

Para a próxima semana operativa, foram declaradas as seguintes ofertas de importação de energia da República Oriental do Uruguai para o Sistema Interligado Nacional - SIN através da conversora de Melo (500 MW).

- **Enel**

Tabela 14 – Energia ofertada para importação

	Oferta de Energia para a Semana de 27/07 a 02/08 (MWmed)						
	Bloco 1	Bloco 2	Bloco 3	Bloco 4	Bloco 5	Bloco 6	Total
Carga Pesada	50	50	25	25	50	50	250
Carga Média	50	50	25	25	50	50	250
Carga Leve	50	50	25	25	50	50	250
CVU (R$/MWh)	582,43	893,46	1.416,30	1.716,05	1.967,02	2.092,50	

- **BTG Pactual**

Tabela 15 – Energia ofertada para importação

	Oferta de Energia para a Semana de 27/07 a 02/08 (MWmed)						
	Bloco 1	Bloco 2	Bloco 3	Bloco 4	Bloco 5	Bloco 6	Total
Carga Pesada	50	50	25	25	50	50	250
Carga Média	50	50	25	25	50	50	250
Carga Leve	50	50	25	25	50	50	250
CVU (R$/MWh)	592,53	911,00	1.441,78	1.746,09	2.000,87	2.128,26	

7.2. República da Argentina

Para a próxima semana operativa, foi declarada a seguinte oferta de importação de energia da República da Argentina para o SIN através das conversoras de Garabi 1 (1.100 MW) e Garabi 2 (1.100 MW).

- **Enel**

Tabela 16 – Energia ofertada para importação

	Oferta de Energia para a Semana de 27/07 a 02/08 (MWmed)			
	Bloco 1	Bloco 2	Bloco 3	Total
Carga Pesada	500	500	300	1300
Carga Média	500	500	300	1300
Carga Leve	500	500	300	1300
CVU (R$/MWh)	1.205,07	1.479,47	1.686,21	

Nota: Detalhes sobre a importação de energia vide Portaria Normativa Nº 60/GM/MME, de 29 de dezembro de 2022 disponível em: https://www.in.gov.br/en/web/dou/-/portaria-normativa-n-60/gm/mme-de-29-de-dezembro-de-2022-454963353

O conteúdo desta publicação foi produzido pelo ONS com base em dados e informações de conhecimento público. É de responsabilidade exclusiva dos agentes e demais interessados a obtenção de outros dados e informações, a realização de análises, estudos e avaliações para fins de tomada de decisões, definição de estratégias de atuação, assunção de compromissos e obrigações e quaisquer outras finalidades, em qualquer tempo e sob qualquer condição. É proibida a reprodução ou utilização total ou parcial do presente sem a identificação da fonte.

8. RESUMO DOS RESULTADOS DO PMO

As figuras a seguir apresentam um resumo dos resultados do PMO de Agosto/2024, com informações da Energia Natural Afluente (ENA), da Energia Armazenada (EAR) e do Custo Marginal de Operação (CMO) nos subsistemas do Sistema Interligado Nacional (SIN). São apresentados os valores semanais observados e previstos e o valor esperado dos cenários gerados para o mês de setembro/2024.

Figura 28 – Resumo de Agosto/2024 para o Subsistema Sudeste/Centro-Oeste

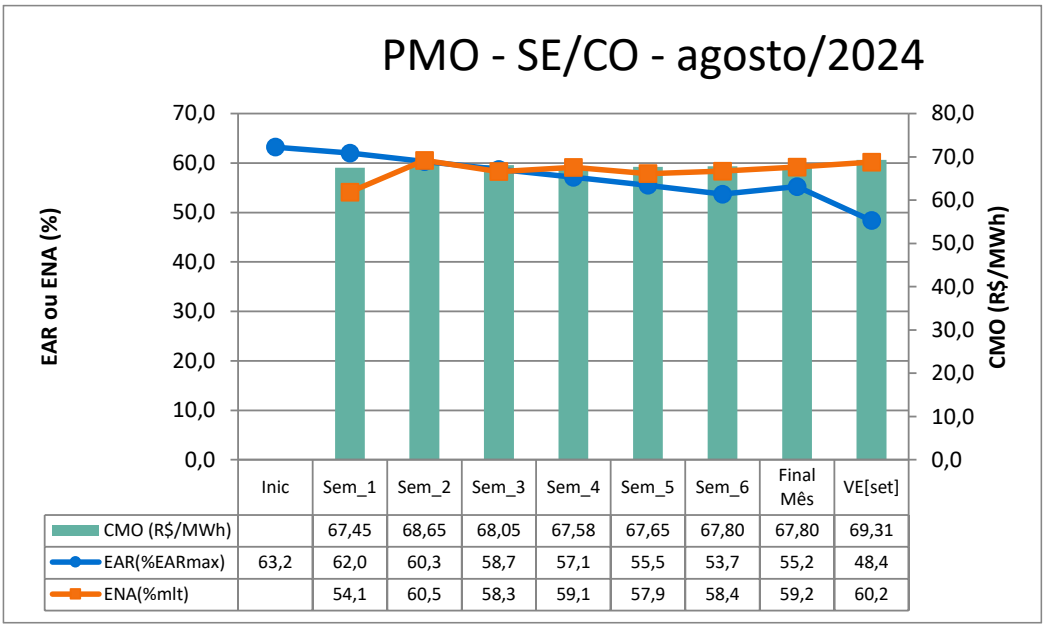

	Inic	Sem_1	Sem_2	Sem_3	Sem_4	Sem_5	Sem_6	Final Mês	VE[set]
CMO (R$/MWh)		67,45	68,65	68,05	67,58	67,65	67,80	67,80	69,31
EAR(%EARmax)	63,2	62,0	60,3	58,7	57,1	55,5	53,7	55,2	48,4
ENA(%mlt)		54,1	60,5	58,3	59,1	57,9	58,4	59,2	60,2

Figura 29 – Resumo de agosto/2024 para o Subsistema Sul

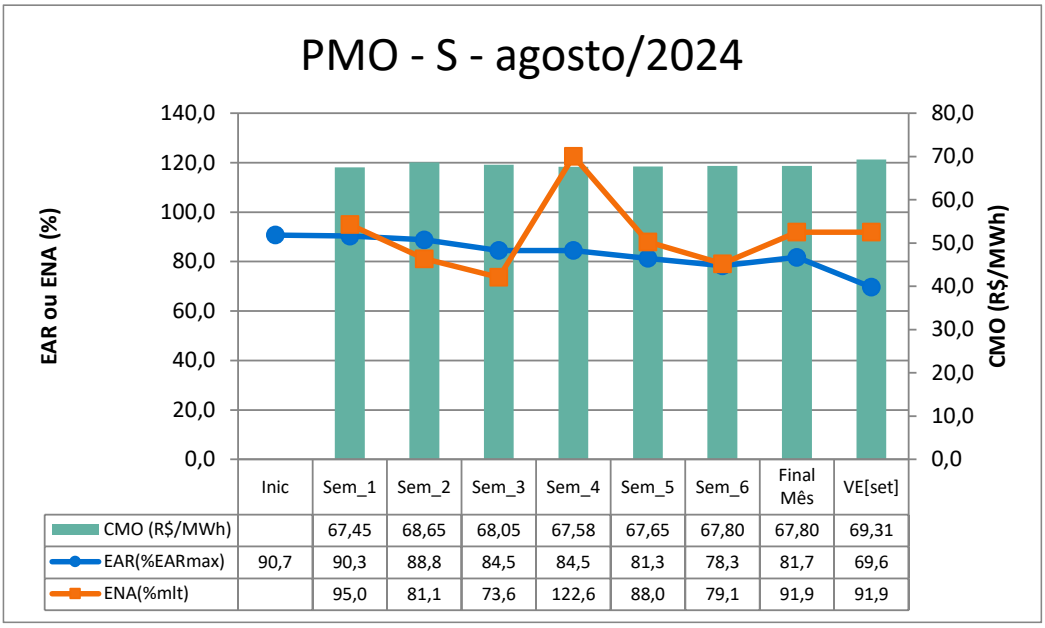

	Inic	Sem_1	Sem_2	Sem_3	Sem_4	Sem_5	Sem_6	Final Mês	VE[set]
CMO (R$/MWh)		67,45	68,65	68,05	67,58	67,65	67,80	67,80	69,31
EAR(%EARmax)	90,7	90,3	88,8	84,5	84,5	81,3	78,3	81,7	69,6
ENA(%mlt)		95,0	81,1	73,6	122,6	88,0	79,1	91,9	91,9

O conteúdo desta publicação foi produzido pelo ONS com base em dados e informações de conhecimento público. É de responsabilidade exclusiva dos agentes e demais interessados a obtenção de outros dados e informações, a realização de análises, estudos e avaliações para fins de tomada de decisões, definição de estratégias de atuação, assunção de compromissos e obrigações e quaisquer outras finalidades, em qualquer tempo e sob qualquer condição. É proibida a reprodução ou utilização total ou parcial do presente sem a identificação da fonte.

Figura 30 – Resumo de agosto/2024 para o Subsistema Nordeste

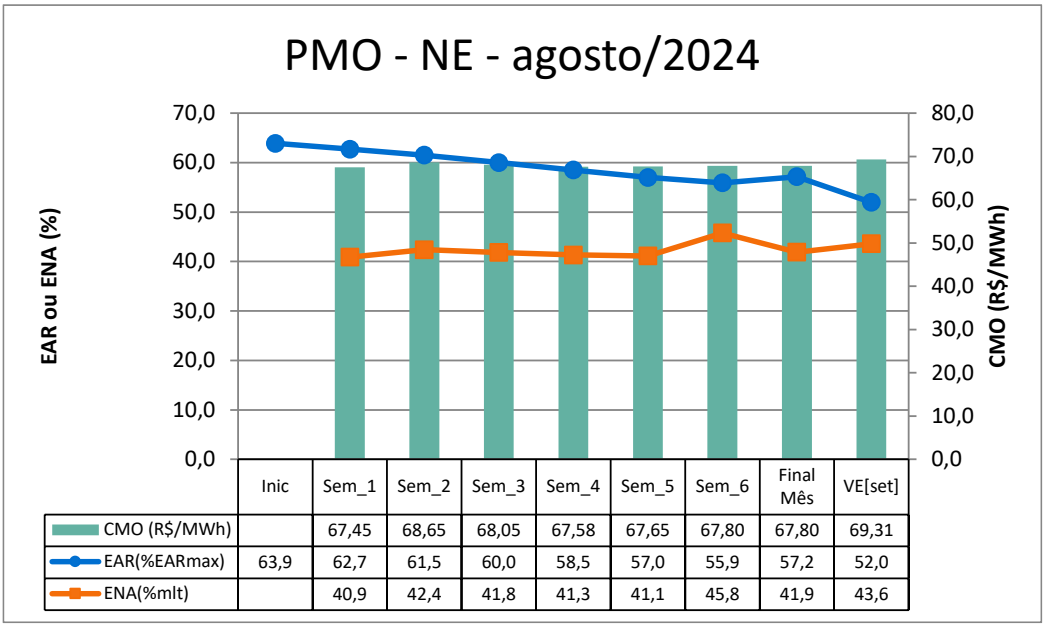

	Inic	Sem_1	Sem_2	Sem_3	Sem_4	Sem_5	Sem_6	Final Mês	VE[set]
CMO (R$/MWh)		67,45	68,65	68,05	67,58	67,65	67,80	67,80	69,31
EAR(%EARmax)	63,9	62,7	61,5	60,0	58,5	57,0	55,9	57,2	52,0
ENA(%mlt)		40,9	42,4	41,8	41,3	41,1	45,8	41,9	43,6

Figura 31 – Resumo de agosto/2024 para o Subsistema Norte

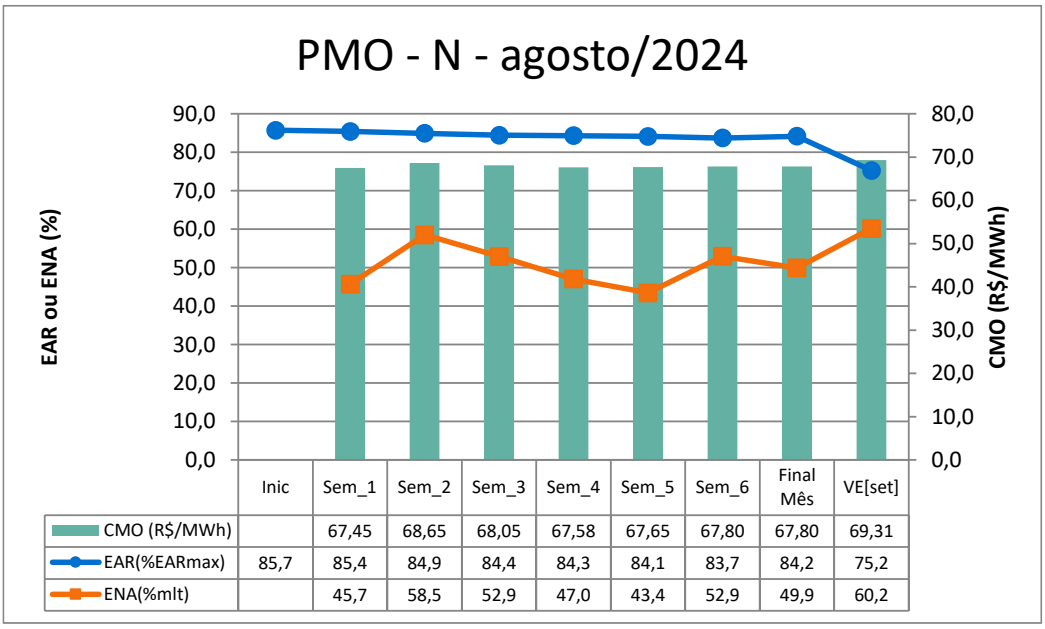

	Inic	Sem_1	Sem_2	Sem_3	Sem_4	Sem_5	Sem_6	Final Mês	VE[set]
CMO (R$/MWh)		67,45	68,65	68,05	67,58	67,65	67,80	67,80	69,31
EAR(%EARmax)	85,7	85,4	84,9	84,4	84,3	84,1	83,7	84,2	75,2
ENA(%mlt)		45,7	58,5	52,9	47,0	43,4	52,9	49,9	60,2

O conteúdo desta publicação foi produzido pelo ONS com base em dados e informações de conhecimento público. É de responsabilidade exclusiva dos agentes e demais interessados a obtenção de outros dados e informações, a realização de análises, estudos e avaliações para fins de tomada de decisões, definição de estratégias de atuação, assunção de compromissos e obrigações e quaisquer outras finalidades, em qualquer tempo e sob qualquer condição. É proibida a reprodução ou utilização total ou parcial do presente sem a identificação da fonte.

9. ARMAZENAMENTOS OPERATIVOS

Para uma melhor avaliação de diversos cenários hidrometeorológicos, notadamente, aqueles de curto prazo e suas influências nas previsões de vazões nos subsistemas, os resultados deste PMO contemplam cenários de afluências visando melhor representar a ocorrência de precipitação e, consequentemente, seus efeitos sobre as afluências e armazenamentos.

Apresentamos a seguir as correspondentes energias naturais afluentes e os resultados obtidos com a aplicação do cenário de afluência utilizado no estudo.

Tabela 17 – Previsão de ENA do caso de valor esperado das previsões de afluência

Subsistema	ENERGIAS NATURAIS AFLUENTES			
	Previsão Semanal		Previsão Mensal	
	(MWmed)	%MLT	(MWmed)	%MLT
SE/CO	13.071	54	12.147	59
Sul	10.110	95	9.196	92
Nordeste	1.482	41	1.374	42
Norte	2.006	43	1.589	50

Tabela 18 – Previsão de %EARmáx para o final do mês

Subsistema	% EARmáx 26/07	% EARmáx - 31/08
	NÍVEL INICIAL	NÍVEL PMO
SE/CO	63,2	55,2
Sul	90,7	80,9
Nordeste	63,9	56,8
Norte	85,7	84,0

O conteúdo desta publicação foi produzido pelo ONS com base em dados e informações de conhecimento público. É de responsabilidade exclusiva dos agentes e demais interessados a obtenção de outros dados e informações, a realização de análises, estudos e avaliações para fins de tomada de decisões, definição de estratégias de atuação, assunção de compromissos e obrigações e quaisquer outras finalidades, em qualquer tempo e sob qualquer condição. É proibida a reprodução ou utilização total ou parcial do presente sem a identificação da fonte.

10. RESERVATÓRIOS EQUIVALENTES DE ENERGIA

A seguir são apresentadas as previsões de Energia Natural Afluente para a próxima semana operativa e para o mês de agosto, bem como as previsões de Energia Armazenada nos Reservatórios Equivalentes de Energia – REE, deste PMO de Agosto de 2024.

Tabela 19 – Previsão de ENA por REE

Valor Esperado das Energias Naturais Afluentes				
REE	Previsão Semanal		Previsão Mensal	
	27/07/2024 a 02/08/2024		ago/24	
	(MWmed)	%MLT	(MWmed)	%MLT
Sudeste	1.628	58	1.494	60
Madeira	1.599	47	1.348	57
Teles Pires	574	61	508	64
Itaipu	1.802	61	1.790	69
Paraná	6.539	55	6.103	59
Paranapanema	917	43	896	48
Sul	4.746	79	5.175	87
Iguaçu	5.364	116	4.020	100
Nordeste	1.482	41	1.374	42
Norte	1.141	48	960	53
Belo Monte	378	28	190	28
Manaus	611	65	480	70

Tabela 20 – Previsão de %EARmáx por REE

% Energia Armazenável Máxima		
REE	Previsão Semanal	Previsão Mensal
	02-ago	31-ago
	(%EARmáx)	(%EARmáx)
Sudeste	69,1	64,4
Madeira	56,0	46,8
Teles Pires	60,8	49,7
Itaipu	61,1	100,0
Paraná	60,6	52,4
Paranapanema	47,3	47,2
Sul	88,8	74,2
Iguaçu	91,8	87,5
Nordeste	62,7	56,8
Norte	88,2	86,8
Belo Monte	91,0	100,0
Manaus	31,9	30,6

O conteúdo desta publicação foi produzido pelo ONS com base em dados e informações de conhecimento público. É de responsabilidade exclusiva dos agentes e demais interessados a obtenção de outros dados e informações, a realização de análises, estudos e avaliações para fins de tomada de decisões, definição de estratégias de atuação, assunção de compromissos e obrigações e quaisquer outras finalidades, em qualquer tempo e sob qualquer condição. É proibida a reprodução ou utilização total ou parcial do presente sem a identificação da fonte.

11. DESPACHO TÉRMICO POR MODALIDADE, PATAMAR DE CARGA E USINA

Nas tabelas abaixo, a diferenciação entre geração por inflexibilidade e por ordem de mérito tem caráter informativo, com o objetivo de detalhar a informação de inflexibilidade enviada pelos respectivos agentes para o PMO. Ressalta-se que nas etapas de Programação Diária e Tempo Real, o montante despachado nas usinas termelétricas indicadas por ordem de mérito é plenamente intitulado como ordem de mérito.

REGIÃO SUDESTE/CENTRO-OESTE

Térmicas Potência (MW)	Combustível	CVU	Inflexibilidade			Ordem de Mérito			Total Mérito e INFL.			Razão Elétrica			Total UTE		
			P	M	L	P	M	L	P	M	L	P	M	L	P	M	L
ATLAN_CSA (255)	Resíduos	0,00	3,1	3,1	3,1				3,1	3,1	3,1				3,1	3,1	3,1
CUIABA CC (529)	Gás	---															
DAIA (44)	Diesel	---															
TNORTE 2 (349)	Óleo	---															
W.ARJONA (177)	Gás	---															
W.ARJONA O	Diesel	---															
XAVANTES (54)	Diesel	---															
ANGRA 2 (1350)	Nuclear	20,12	1350,0	1350,0	1350,0	0,0	0,0	0,0	1350,0	1350,0	1350,0				1350,0	1350,0	1350,0
ANGRA 1 (640)	Nuclear	31,17	640,0	640,0	640,0	0,0	0,0	0,0	640,0	640,0	640,0				640,0	640,0	640,0
NORTEFLU 1 (400)	Gás	109,75															
NORTEFLU 2 (100)	Gás	126,35															
O.PINTADA (50)	Biomassa	138,91															
UTE STA VI (41)	Biomassa	150,06	18,0	18,0	18,0				18,0	18,0	18,0				18,0	18,0	18,0
M.AZUL (566)	Gás	166,94															
BAIXADA FL (530)	Gás	179,42															
SANTA CRUZ (500)	GNL	182,65															
NORTEFLU 3 (200)	Gás	243,45															
ATLANTICO (235)	Resíduos	248,36	215,3	215,3	215,3				215,3	215,3	215,3				215,3	215,3	215,3
LUIZORMELO (204)	GNL	273,27															
ST.CRUZ 34 (436)	Óleo	310,41															
UTE GNA I (1338)	Gás	345,20															
TERMORIO (989)	Gás	406,85															
CUBATAO (216)	Gás	430,23															
PIRAT.12 O (200)	Gás	470,34															
IBIRITE (235)	Gás	605,41															
NORTEFLU 4 (127)	Gás	725,53															
T.LAGOAS (350)	Gás	735,31															
J.FORA (87)	Gás	850,88															
KARKEY 013 (259)	Gás	868,44	30,0	30,0	30,0				30,0	30,0	30,0				30,0	30,0	30,0
KARKEY 019 (116)	Gás	868,44															
SEROPEDICA (360)	Gás	911,27															
T.MACAE (929)	Gás	931,09															
PAULINIA (16)	Gás	941,00	15,7	15,7	15,7				15,7	15,7	15,7				15,7	15,7	15,7
NPIRATINGA (572)	Gás	972,56															
PORSUD II (78)	Gás	1013,31															
PORSUD I (116)	Gás	1014,35															
VIANA (175)	Óleo	1134,33															
LORM_PCS (36)	Gás	1265,17															
POVOACAO I (75)	Gás	1265,17															
VIANA I (37)	Gás	1265,17															
PALMEIR_GO (176)	Diesel	1730,87															
TOTAL SE/CO (13147)			2272,1	2272,1	2272,1	0,0	0,0	0,0	2272,1	2272,1	2272,1	0,0	0,0	0,0	2272,1	2272,1	2272,1

REGIÃO SUL

Térmicas Potência (MW)	Combustível	CVU	Inflexibilidade			Ordem de Mérito			Total Mérito e INFL.			Razão Elétrica			Total UTE		
			P	M	L	P	M	L	P	M	L	P	M	L	P	M	L
ARAUCARIA (484)	Gás	---															
URUGUAIANA (640)	Gás	---															
PAMPA SUL (345)	Carvão	96,61															
SAO SEPE (8)	Biomassa	108,38	4,0	4,0	4,0				4,0	4,0	4,0				4,0	4,0	4,0
CANDIOTA_3 (350)	Carvão	111,48															
J.LACER. C (330)	Carvão	325,27	300,0	300,0	300,0				300,0	300,0	300,0				300,0	300,0	300,0
FIGUEIRA (20)	Carvão	330,64															
J.LACER. B (220)	Carvão	378,90	220,0	220,0	220,0				220,0	220,0	220,0				220,0	220,0	220,0
J.LAC. A2 (110)	Carvão	387,75	50,0	50,0	50,0				50,0	50,0	50,0				50,0	50,0	50,0
J.LAC. A1 (80)	Carvão	453,14															
B.BONITA I (10)	Gás	742,99	3,7	3,7	3,7				3,7	3,7	3,7				3,7	3,7	3,7
CANOAS (249)	Gás	1130,30															
TOTAL SUL (2846)			577,7	577,7	577,7	0,0	0,0	0,0	577,7	577,7	577,7	0,0	0,0	0,0	577,7	577,7	577,7

O conteúdo desta publicação foi produzido pelo ONS com base em dados e informações de conhecimento público. É de responsabilidade exclusiva dos agentes e demais interessados a obtenção de outros dados e informações, a realização de análises, estudos e avaliações para fins de tomada de decisões, definição de estratégias de atuação, assunção de compromissos e obrigações e quaisquer outras finalidades, em qualquer tempo e sob qualquer condição. É proibida a reprodução ou utilização total ou parcial do presente sem a identificação da fonte.

REGIÃO NORDESTE

Térmicas Potência (MW)	Combustível	CVU	Inflexibilidade			Ordem de Mérito			Total Mérito e INFL.			Razão Elétrica			Total UTE		
			P	M	L	P	M	L	P	M	L	P	M	L	P	M	L
PETROLINA (136)	Óleo	---															
POTIGUAR (53)	Diesel	---															
POTIGUAR_3 (66)	Diesel	---															
TERMOPE (550)	Gás	---															
ERB CANDEI (17)	Biomassa	108,45															
PROSP_I (28)	Gás	204,55															
PROSP_III (56)	Gás	208,41															
PROSP_II (37)	Gás	323,93															
P.PECEM1 (720)	Carvão	340,99															
P.PECEM2 (365)	Carvão	347,59															
PSERGIPE I (1593)	GNL	372,64															
VALE ACU (368)	Gás	450,86															
T.BAHIA (186)	Gás	541,51															
TERMOCEARA (223)	Gás	563,26															
PERNAMBU_3 (201)	Óleo	977,59															
MARACANAU (168)	Óleo	1103,08															
TERMOCABO (50)	Óleo	1120,43															
TERMONE (171)	Óleo	1124,78															
TERMOPB (171)	Óleo	1124,78															
CAMPINA_GR (169)	Óleo	1134,35															
SUAPE II (381)	Óleo	1159,17															
GLOBAL I (149)	Óleo	1285,28															
GLOBAL II (149)	Óleo	1285,28															
TOTAL NE (6007)			0,0	0,0	0,0	0,0	0,0	0,0	0,0	0,0	0,0	0,0	0,0	0,0	0,0	0,0	0,0

REGIÃO NORTE

Térmicas Potência (MW)	Combustível	CVU	Inflexibilidade			Ordem de Mérito			Total Mérito e INFL.			Razão Elétrica			Total UTE		
			P	M	L	P	M	L	P	M	L	P	M	L	P	M	L
C. ROCHA (85)	Gás	0,00	65,0	65,0	65,0				65,0	65,0	65,0				65,0	65,0	65,0
JARAQUI (75)	Gás	0,00	63,0	63,0	63,0				63,0	63,0	63,0				63,0	63,0	63,0
MANAUARA (73)	Gás	0,00	48,1	48,7	42,4				48,1	48,7	42,4				48,1	48,7	42,4
PONTA NEGR (73)	Gás	0,00	64,0	64,0	64,0				64,0	64,0	64,0				64,0	64,0	64,0
TAMBAQUI (93)	Gás	0,00	63,0	63,0	63,0				63,0	63,0	63,0				63,0	63,0	63,0
APARECIDA (166)	Gás	94,62	75,0	75,0	75,0				75,0	75,0	75,0				75,0	75,0	75,0
UTE MAUA 3 (591)	Gás	94,62	264,0	264,0	264,0				264,0	264,0	264,0				264,0	264,0	264,0
MARANHAO3 (519)	Gás	105,87	276,0	231,0	102,7				276,0	231,0	102,7				276,0	231,0	102,7
PARNAIB_IV (56)	Gás	151,69	19,1	19,1	19,1				19,1	19,1	19,1				19,1	19,1	19,1
MARANHAO V (338)	Gás	169,99	113,0	113,0	113,0				113,0	113,0	113,0				113,0	113,0	113,0
MARANHAOIV (338)	Gás	169,99	113,0	113,0	113,0				113,0	113,0	113,0				113,0	113,0	113,0
PARNAIBA_V (386)	Vapor	216,45	123,7	123,7	123,7				123,7	123,7	123,7				123,7	123,7	123,7
N.VENECIA2 (270)	Gás	286,88	41,2	35,5	20,6				41,2	35,5	20,6				41,2	35,5	20,6
P. ITAQUI (360)	Carvão	339,90															
GERAMAR1 (166)	Óleo	1134,31															
GERAMAR2 (166)	Óleo	1134,31															
TOTAL NORTE (3756)			1328,1	1278,0	1128,5	0,0	0,0	0,0	1328,1	1278,0	1128,5	0,0	0,0	0,0	1328,1	1278,0	1128,5

O conteúdo desta publicação foi produzido pelo ONS com base em dados e informações de conhecimento público. É de responsabilidade exclusiva dos agentes e demais interessados a obtenção de outros dados e informações, a realização de análises, estudos e avaliações para fins de tomada de decisões, definição de estratégias de atuação, assunção de compromissos e obrigações e quaisquer outras finalidades, em qualquer tempo e sob qualquer condição. É proibida a reprodução ou utilização total ou parcial do presente sem a identificação da fonte.