1. APRESENTAÇÃO

No mês de fevereiro houve ocorrência de precipitação superior à média mensal nas bacias dos rios Grande, Paranaíba e São Francisco. Nas demais bacias hidrográficas de interesse do SIN apesar da ocorrência de precipitação, os totais observados foram inferiores à média mensal.

Na semana de 21/02 a 27/02 houve precipitação foram observados nas bacias dos rios Paranaíba, São Francisco, Tocantins e Madeira

Na semana de 28/02 a 06/03 deve ocorrer precipitação nas bacias dos rios São Francisco e Tocantins, com os valores ficando acima da média semanal.

Os valores médios semanais do Custo Marginal de Operação – CMO dos subsistemas do SIN sofreram as seguintes alterações em relação à semana anterior:

- SE/CO: de R$ 316,18/MWh para R$ 477,01/MWh
- Sul: de R$ 316,18/MWh para R$ 489,76/MWh
- Nordeste: de R$ 316,18/MWh para R$ 306,43/MWh
- Norte: de R$ 316,18/MWh para R$ 306,43/MWh

Desde o dia 01/01/2020, o despacho por ordem de mérito é indicado diariamente pelos resultados do modelo DESSEM. Assim, o despacho por ordem de mérito semanal, conforme publicado nesse documento, tem caráter apenas informativo. Da mesma forma, desde o dia 01/01/2021, a formação de preço deixou o formato semanal/patamar de carga e passou a ser horário, de acordo também com os resultados do modelo DESSEM.

2. NOTÍCIAS

Nos dias 26 e 27 de março será realizada a reunião de elaboração do PMO de Abril de 2026, com transmissão ao vivo através do site do ONS.

3. INFORMAÇÕES CONJUNTURAIS PARA ELABORAÇÃO DO PMO

3.1. Informações hidrometeorológicas

3.1.1. Condições antecedentes

No mês de fevereiro, a configuração de um episódio da Zona de Convergência do Atlântico Sul (ZCAS) e a presença de sistemas frontais no litoral da Região Sudeste favoreceram a ocorrência de precipitação superior à média mensal nas bacias dos rios Grande, Paranaíba e São Francisco. Nas demais bacias hidrográficas de interesse do SIN apesar da ocorrência de precipitação, os totais observados foram inferiores à média mensal (Figura 1).

O conteúdo desta publicação foi produzido pelo ONS com base em dados e informações de conhecimento público. É de responsabilidade exclusiva dos agentes e demais interessados a obtenção de outros dados e informações, a realização de análises, estudos e avaliações para fins de tomada de decisões, definição de estratégias de atuação, assunção de compromissos e obrigações e quaisquer outras finalidades, em qualquer tempo e sob qualquer condição. É proibida a reprodução ou utilização total ou parcial do presente sem a identificação da fonte.

Figura 1 - Mapa de anomalia da precipitação acumulada (mm) – Fevereiro/2026

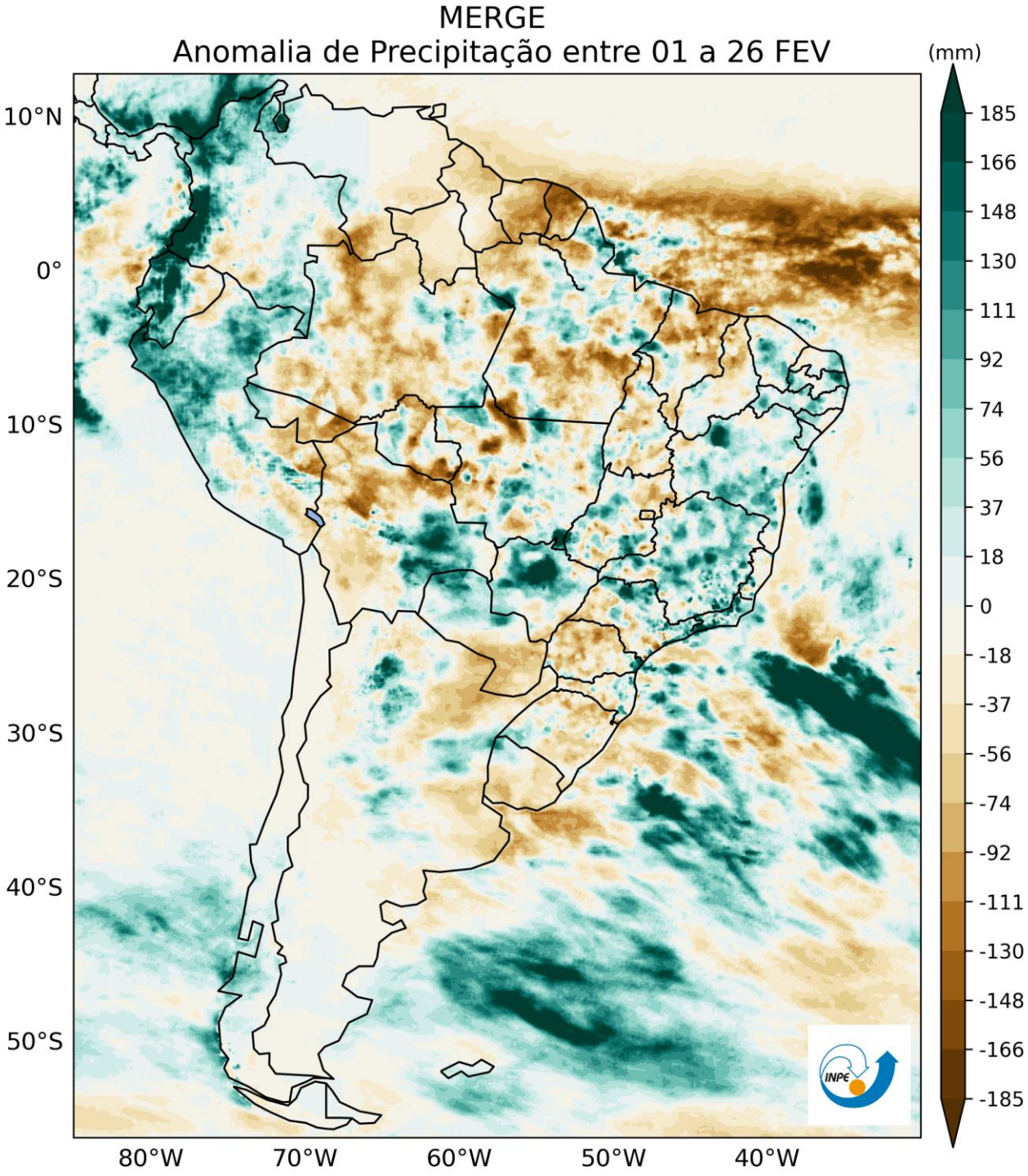

Fonte: Centro de Previsão de Tempo e Estudos Climáticos - CPTEC.

A semana em curso iniciou com a atuação de uma frente fria no litoral da Região Sudeste que ocasionou precipitação nas bacias dessa região, sendo que no final da semana uma nova frente fria avançou pelas Regiões Sul e Sudeste ocasionando precipitação nessas regiões. As Regiões Norte, Centro-Oeste e o interior do Nordeste apresentaram pancadas de chuva no decorrer da semana. Os maiores totais de precipitação foram observados nas bacias dos rios Paranaíba, São Francisco, Tocantins e Madeira (Figura 2).

O conteúdo desta publicação foi produzido pelo ONS com base em dados e informações de conhecimento público. É de responsabilidade exclusiva dos agentes e demais interessados a obtenção de outros dados e informações, a realização de análises, estudos e avaliações para fins de tomada de decisões, definição de estratégias de atuação, assunção de compromissos e obrigações e quaisquer outras finalidades, em qualquer tempo e sob qualquer condição. É proibida a reprodução ou utilização total ou parcial do presente sem a identificação da fonte.

Figura 2 - Precipitação observada (mm) no período de 21 a 26/02/2026

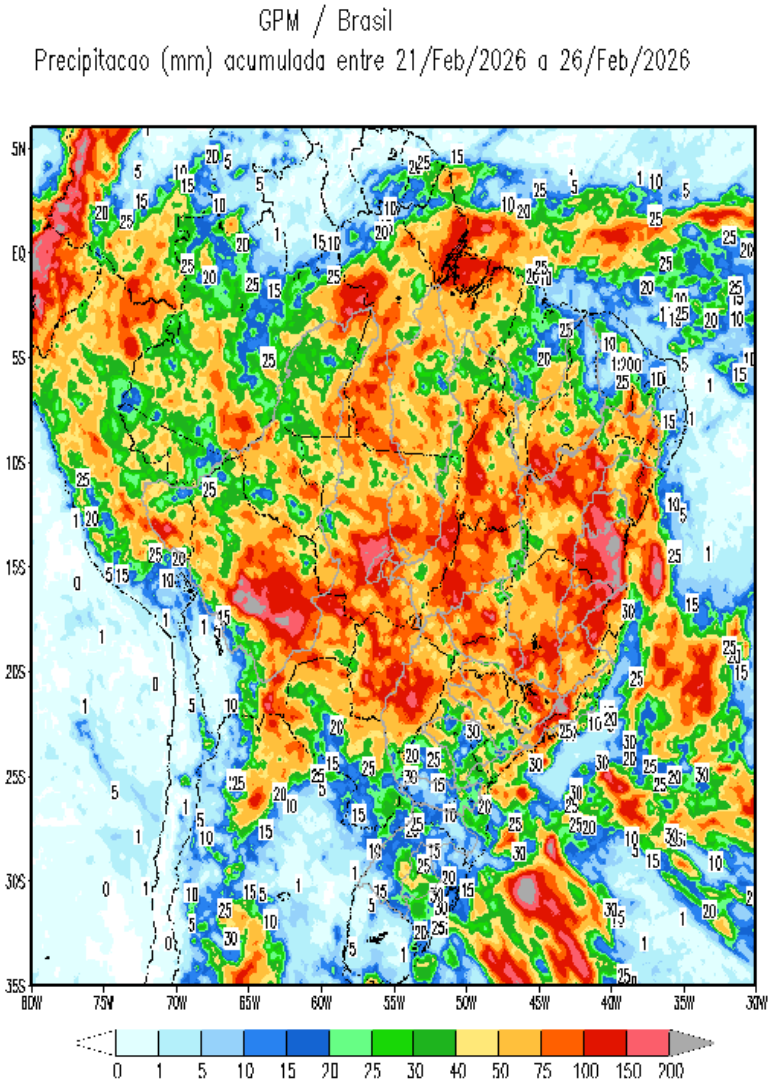

A Tabela 1 apresenta as energias naturais afluentes das semanas recentes. São apresentados os valores verificados na semana 14/02/2026 a 20/02/2026 e os estimados para fechamento da semana de 21/02/2026 a 27/02/2026.

Tabela 1 – Tendência hidrológica da ENA do PMO de Março/2026

PMO de Março/2026 - ENAs verificadas e estimadas				
Subsistema	14/02 a 20/02/2026		21/02 a 27/02/2026	
	MWmed	%MLT	MWmed	%MLT
SE/CO	64.613	91	61.710	87
S	6.028	73	4.466	54
NE	14.511	102	16.472	116
N	15.405	68	15.442	68

O conteúdo desta publicação foi produzido pelo ONS com base em dados e informações de conhecimento público. É de responsabilidade exclusiva dos agentes e demais interessados a obtenção de outros dados e informações, a realização de análises, estudos e avaliações para fins de tomada de decisões, definição de estratégias de atuação, assunção de compromissos e obrigações e quaisquer outras finalidades, em qualquer tempo e sob qualquer condição. É proibida a reprodução ou utilização total ou parcial do presente sem a identificação da fonte.

3.1.2. Climatologia para o trimestre março-abril-maio

Para o trimestre março-abril-maio (MAM) de 2026, o cenário mais provável é de precipitação entre os tercis normal e abaixo da média para as principais bacias do SIN.

Climatologicamente, no decorrer do trimestre MAM os maiores totais de precipitação recuam para a Região Norte, e esse período é caraterizado pelo início da estação seca na Região Sudeste e no interior do Nordeste (Figura 3).

Figura 3 - Climatologia de precipitação para o trimestre março-abril-maio

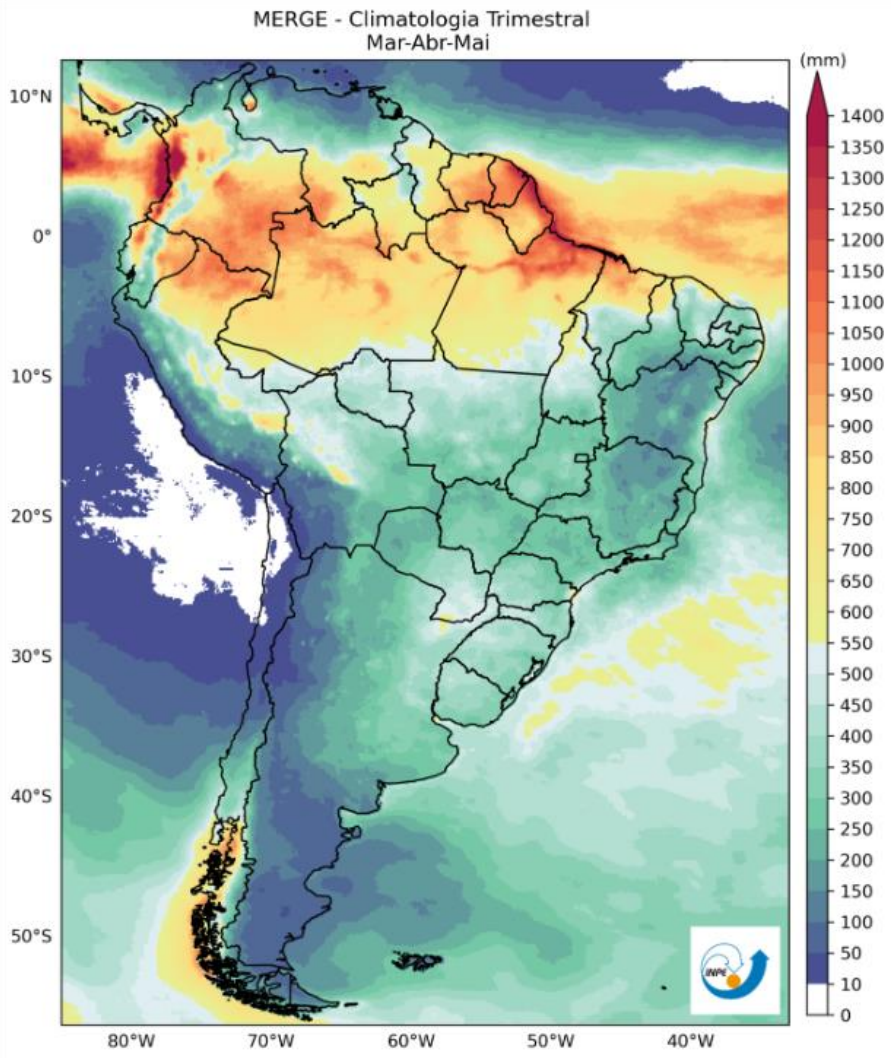

Fonte: Centro de Previsão de Tempo e Estudos Climáticos - CPTEC.

O conteúdo desta publicação foi produzido pelo ONS com base em dados e informações de conhecimento público. É de responsabilidade exclusiva dos agentes e demais interessados a obtenção de outros dados e informações, a realização de análises, estudos e avaliações para fins de tomada de decisões, definição de estratégias de atuação, assunção de compromissos e obrigações e quaisquer outras finalidades, em qualquer tempo e sob qualquer condição. É proibida a reprodução ou utilização total ou parcial do presente sem a identificação da fonte.

3.1.3. Previsão para a próxima semana

Na próxima semana operativa a frente fria avança pelo Espírito Santo e se mantém estacionária no sul da Bahia ocasionando precipitação em Minas Gerais, Espírito Santo, Goiás e Mato Grosso, e nas Regiões Nordeste e Norte no decorrer da próxima semana. Na Região Sul predomina a condição de estiagem. Os maiores totais de precipitação estão previstos para as bacias dos rios São Francisco e Tocantins, com os valores ficando acima da média semanal (Figura 4).

Figura 4 - Precipitação acumulada prevista pelo modelo ECMWF - período de 28/02 a 06/03/2026

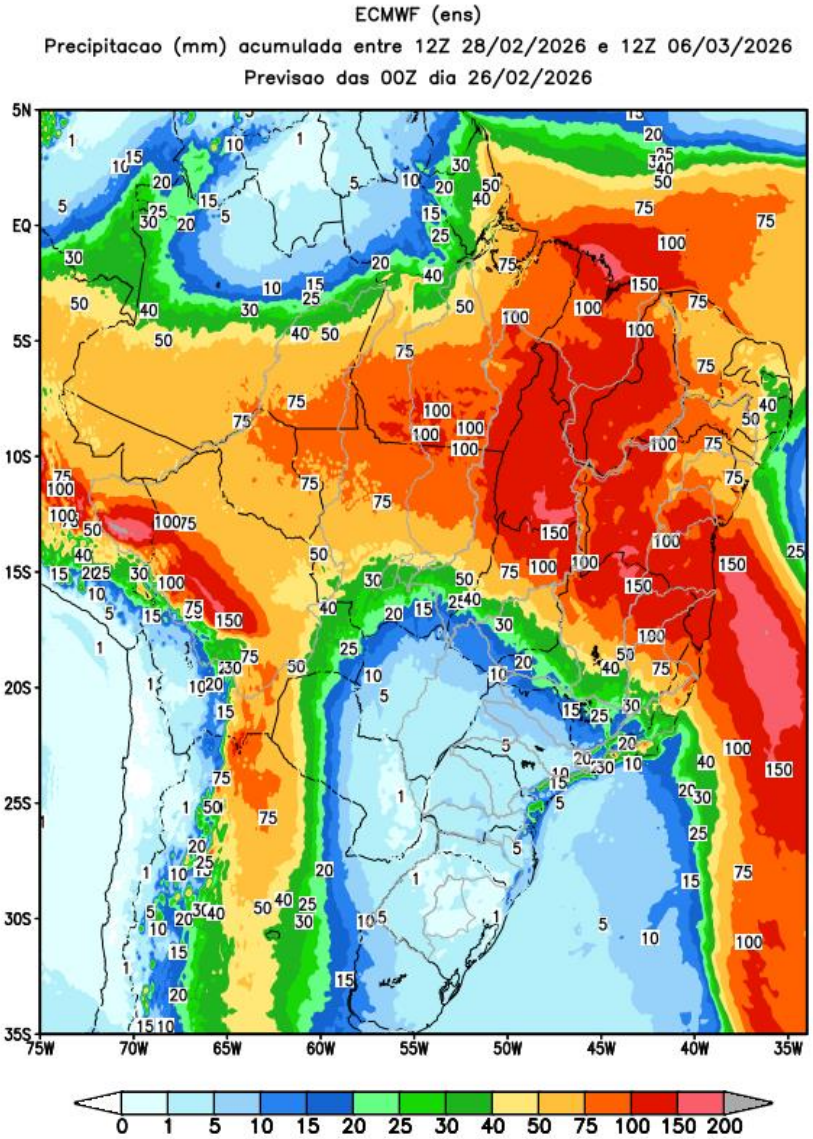

Em comparação com os valores estimados para a semana em curso, prevê-se para a próxima semana operativa ascensão nas afluências dos subsistemas Sudeste/Centro-Oeste e Norte e recessão nas afluências dos subsistemas Sul e Nordeste. A previsão mensal para março indica a ocorrência de afluências abaixo da média histórica para os subsistemas Sudeste/Centro-Oeste, Sul e Norte e acima da média histórica para o subsistema Nordeste.

O conteúdo desta publicação foi produzido pelo ONS com base em dados e informações de conhecimento público. É de responsabilidade exclusiva dos agentes e demais interessados a obtenção de outros dados e informações, a realização de análises, estudos e avaliações para fins de tomada de decisões, definição de estratégias de atuação, assunção de compromissos e obrigações e quaisquer outras finalidades, em qualquer tempo e sob qualquer condição. É proibida a reprodução ou utilização total ou parcial do presente sem a identificação da fonte.

Tabela 2 – Previsão de ENAs do PMO de Março/2026

PMO de Março/2026 - ENAs previstas				
Subsistema	28/02 a 06/03/2026		Mês de março	
	MWmed	%MLT	MWmed	%MLT
SE/CO	62.433	90	55.560	80
S	2.715	37	2.816	40
NE	15.423	110	14.548	104
N	21.277	81	22.448	83

As figuras a seguir ilustram as ENAs semanais previstas no PMO de Março/2026.

Figura 5 - Energias Naturais Afluentes ao Subsistema Sudeste/Centro-Oeste do PMO de Março/2026

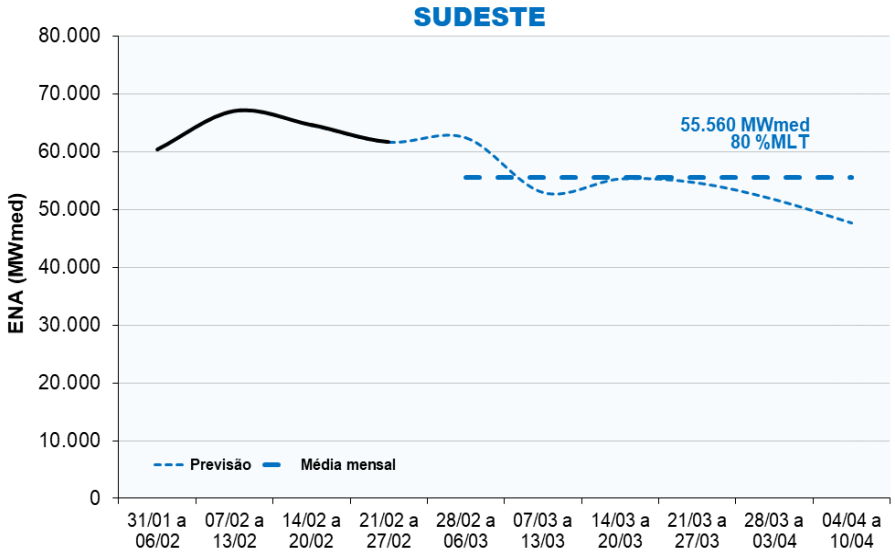

Figura 6 - Energias Naturais Afluentes ao Subsistema Sul do PMO de Março/2026

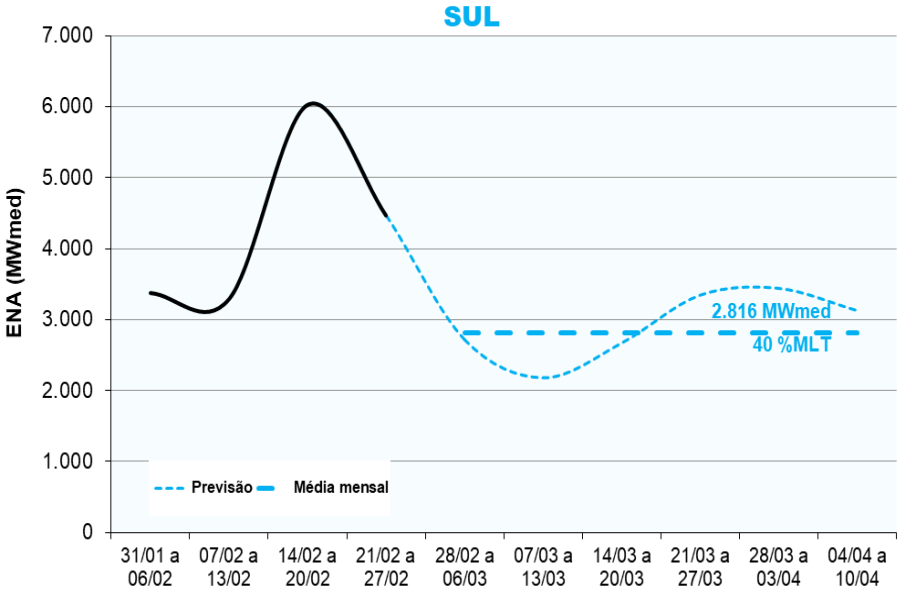

O conteúdo desta publicação foi produzido pelo ONS com base em dados e informações de conhecimento público. É de responsabilidade exclusiva dos agentes e demais interessados a obtenção de outros dados e informações, a realização de análises, estudos e avaliações para fins de tomada de decisões, definição de estratégias de atuação, assunção de compromissos e obrigações e quaisquer outras finalidades, em qualquer tempo e sob qualquer condição. É proibida a reprodução ou utilização total ou parcial do presente sem a identificação da fonte.

Figura 7 - Energias Naturais Afluentes ao Subsistema Nordeste do PMO de Março/2026

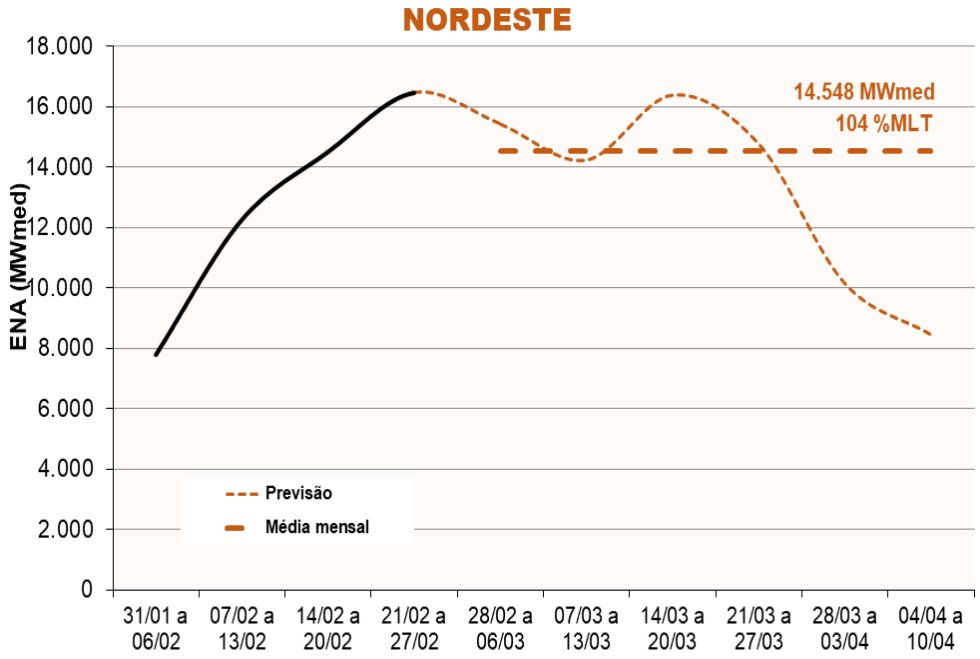

Figura 8 - Energias Naturais Afluentes ao Subsistema Norte do PMO de Março/2026

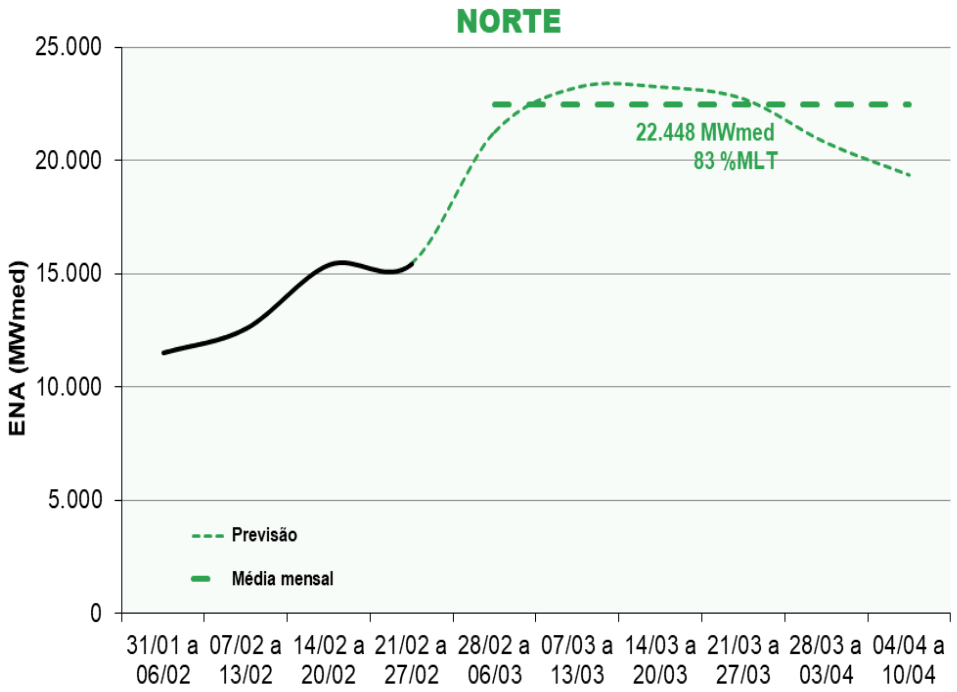

O conteúdo desta publicação foi produzido pelo ONS com base em dados e informações de conhecimento público. É de responsabilidade exclusiva dos agentes e demais interessados a obtenção de outros dados e informações, a realização de análises, estudos e avaliações para fins de tomada de decisões, definição de estratégias de atuação, assunção de compromissos e obrigações e quaisquer outras finalidades, em qualquer tempo e sob qualquer condição. É proibida a reprodução ou utilização total ou parcial do presente sem a identificação da fonte.

3.1.4. Cenários de ENAs para o PMO de Março/2026

As figuras a seguir apresentam as características dos cenários de energias naturais afluentes gerados no PMO de Março/2026, para acoplamento com a FCF do mês de abril/2026. São mostradas, para os quatro subsistemas, as amplitudes e as Funções de Distribuição Acumulada dos cenários de ENA.

Figura 9 - Amplitude dos Cenários de ENA para o Subsistema Sudeste, em %MLT, para o PMO de Março/2026

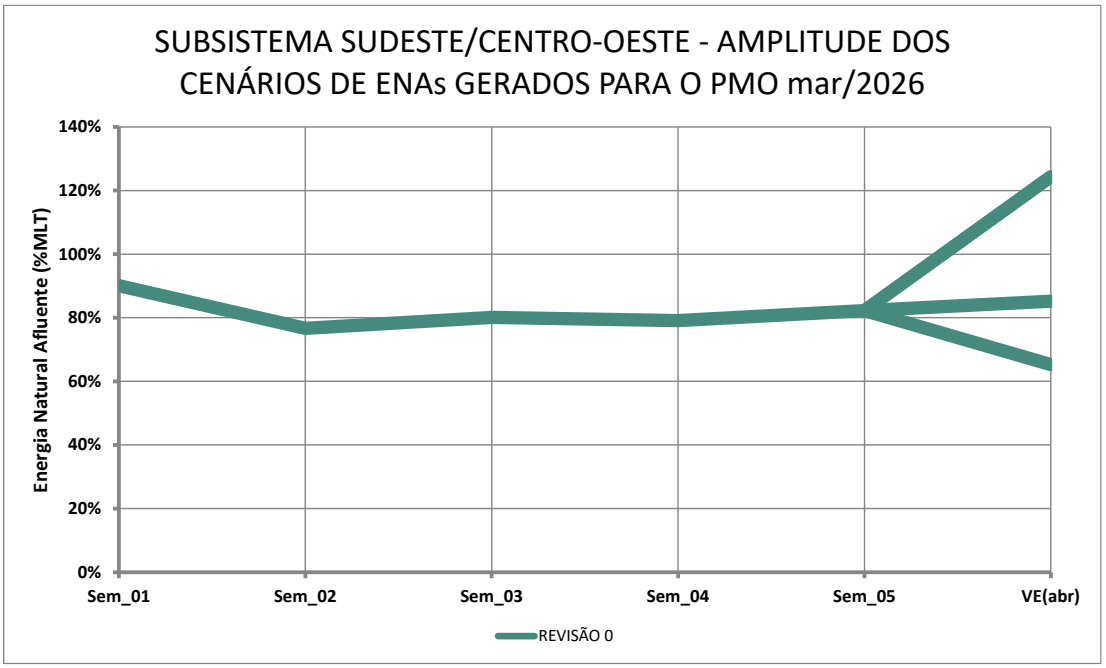

Figura 10 - Função de Distribuição Acumulada dos Cenários para o Subsistema Sudeste/Centro-Oeste para o PMO de Março/2026

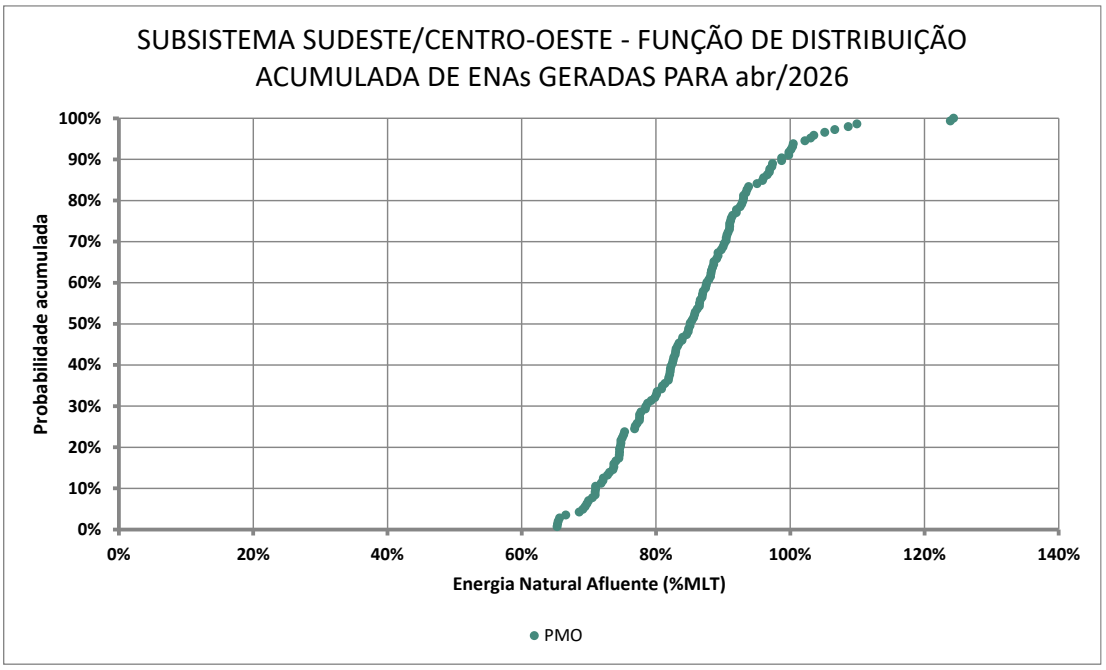

O conteúdo desta publicação foi produzido pelo ONS com base em dados e informações de conhecimento público. É de responsabilidade exclusiva dos agentes e demais interessados a obtenção de outros dados e informações, a realização de análises, estudos e avaliações para fins de tomada de decisões, definição de estratégias de atuação, assunção de compromissos e obrigações e quaisquer outras finalidades, em qualquer tempo e sob qualquer condição. É proibida a reprodução ou utilização total ou parcial do presente sem a identificação da fonte.

Figura 11 - Amplitude dos Cenários de ENA para o Subsistema Sul, em %MLT, para o PMO de Março/2026

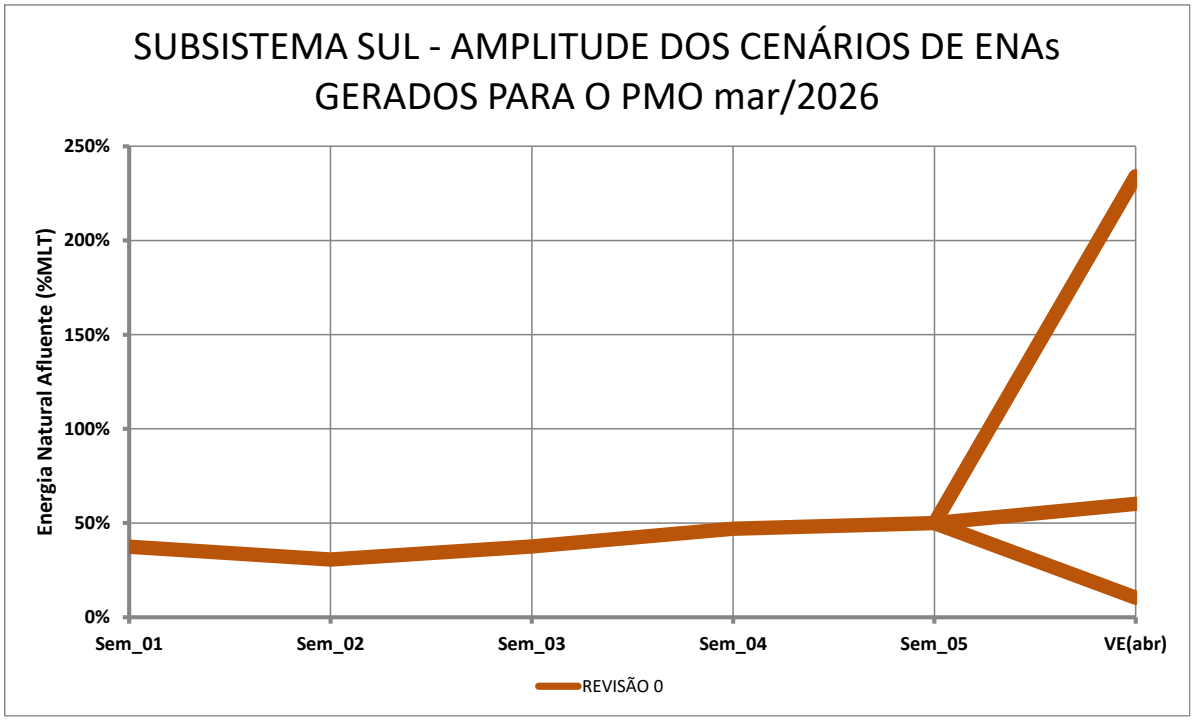

Figura 12 - Função de Distribuição Acumulada dos Cenários para o Subsistema Sul para o PMO de Março/2026

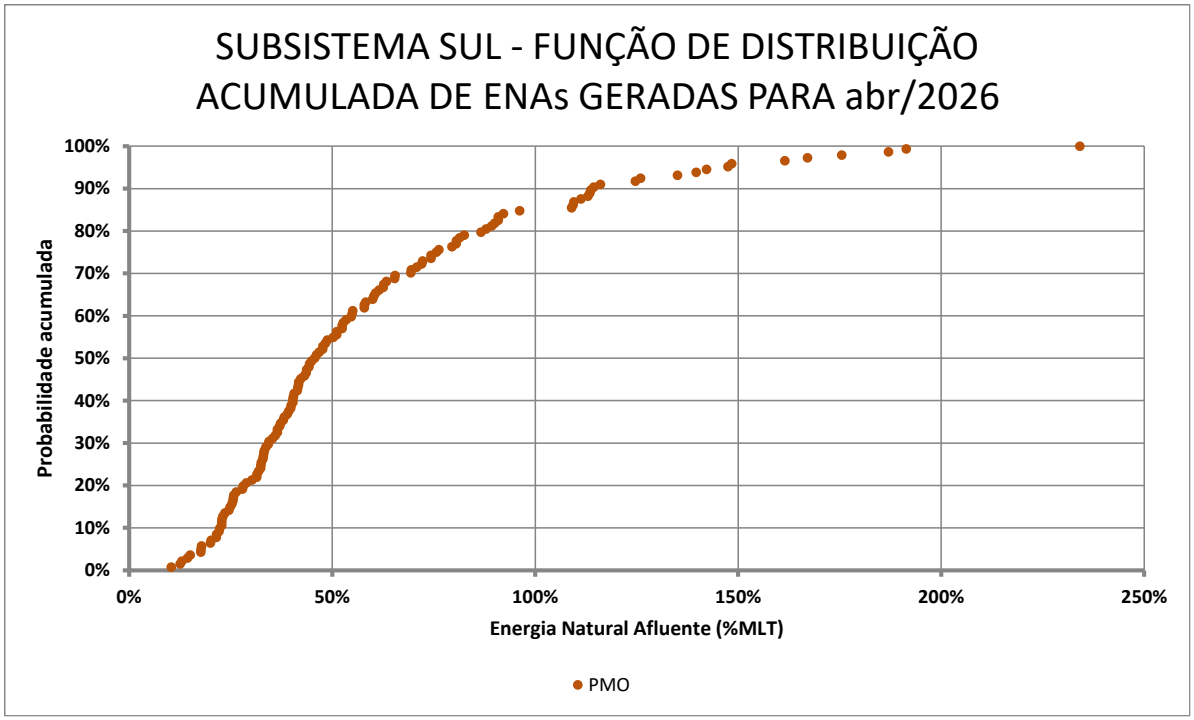

O conteúdo desta publicação foi produzido pelo ONS com base em dados e informações de conhecimento público. É de responsabilidade exclusiva dos agentes e demais interessados a obtenção de outros dados e informações, a realização de análises, estudos e avaliações para fins de tomada de decisões, definição de estratégias de atuação, assunção de compromissos e obrigações e quaisquer outras finalidades, em qualquer tempo e sob qualquer condição. É proibida a reprodução ou utilização total ou parcial do presente sem a identificação da fonte.

Figura 13 - Amplitude dos Cenários de ENA para o Subsistema Nordeste em %MLT, para o PMO de Março/2026

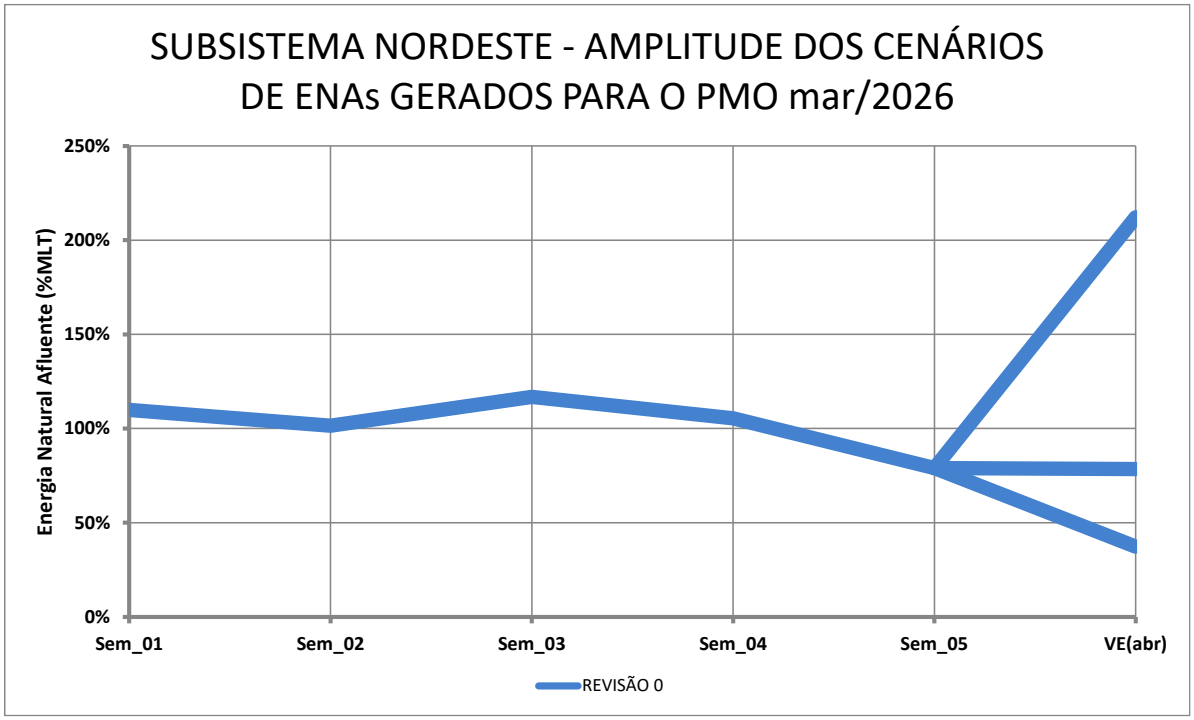

Figura 14 - Função de Distribuição Acumulada dos Cenários para o Subsistema Nordeste para o PMO de Março/2026

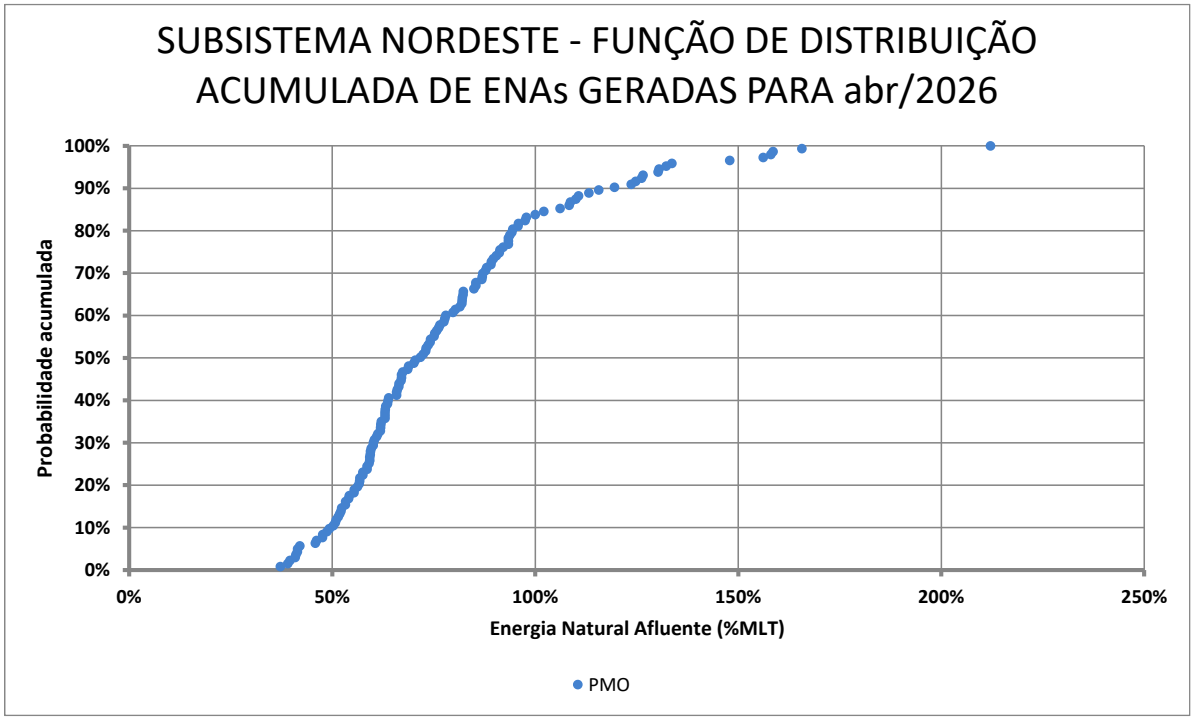

O conteúdo desta publicação foi produzido pelo ONS com base em dados e informações de conhecimento público. É de responsabilidade exclusiva dos agentes e demais interessados a obtenção de outros dados e informações, a realização de análises, estudos e avaliações para fins de tomada de decisões, definição de estratégias de atuação, assunção de compromissos e obrigações e quaisquer outras finalidades, em qualquer tempo e sob qualquer condição. É proibida a reprodução ou utilização total ou parcial do presente sem a identificação da fonte.

Figura 15 - Amplitude dos Cenários de ENA para o Subsistema Norte, em %MLT, para o PMO de Março/2026

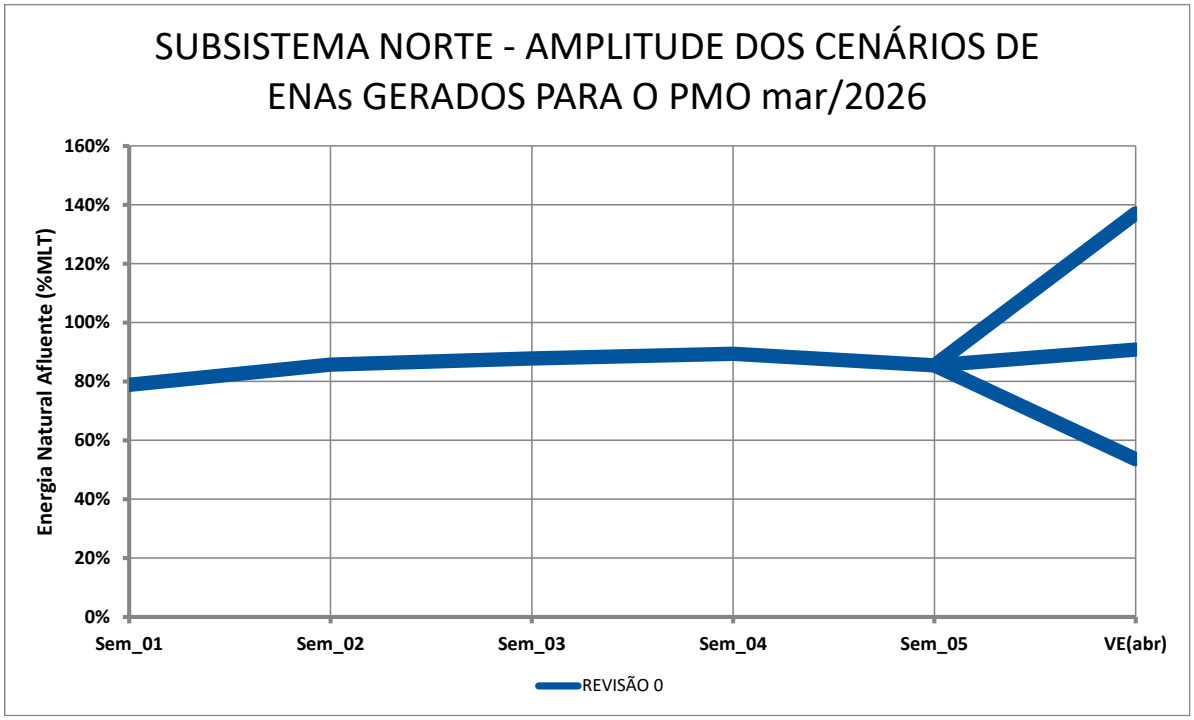

Figura 16 - Função de Distribuição Acumulada dos Cenários para o Subsistema Norte para o PMO de Março/2026

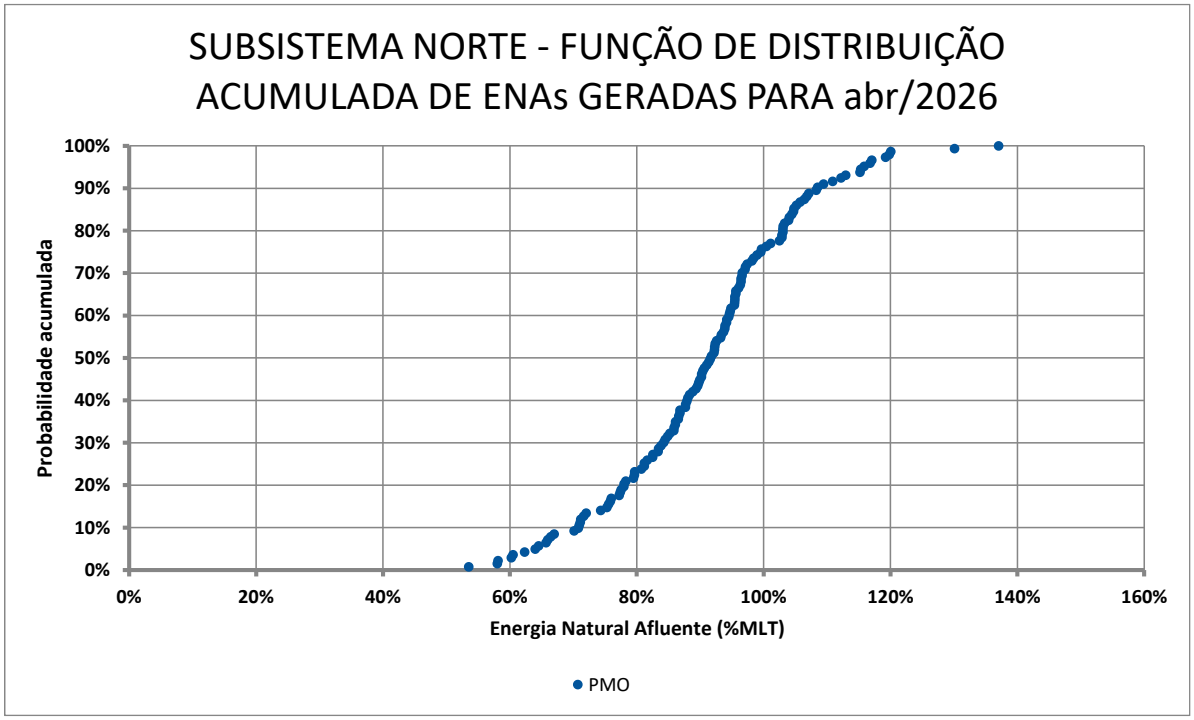

O conteúdo desta publicação foi produzido pelo ONS com base em dados e informações de conhecimento público. É de responsabilidade exclusiva dos agentes e demais interessados a obtenção de outros dados e informações, a realização de análises, estudos e avaliações para fins de tomada de decisões, definição de estratégias de atuação, assunção de compromissos e obrigações e quaisquer outras finalidades, em qualquer tempo e sob qualquer condição. É proibida a reprodução ou utilização total ou parcial do presente sem a identificação da fonte.

Os valores da MLT (Média de Longo Termo) das energias naturais afluentes para os meses de março/2026 e abril/2026 são apresentados na tabela a seguir.

Tabela 3 – MLT da ENA nos meses de março/2026 e abril/2026

MLT das ENAs (MWmed)		
Subsistema	março	abril
SE/CO	69.061	54.753
S	7.105	6.573
NE	14.022	11.336
N	26.896	27.132

3.2. Limites de Intercâmbio entre Subsistemas

Os limites elétricos de intercâmbio de energia entre subsistemas são de fundamental importância para o processo de otimização energética, sendo determinantes para a definição das políticas de operação e do CMO para cada subsistema. Estes limites são influenciados por intervenções na malha de transmissão, notadamente na primeira semana operativa. O diagrama a seguir ilustra os fluxos notáveis do SIN e os limites aplicados neste PMO.

Figura 17 – Interligações entre regiões

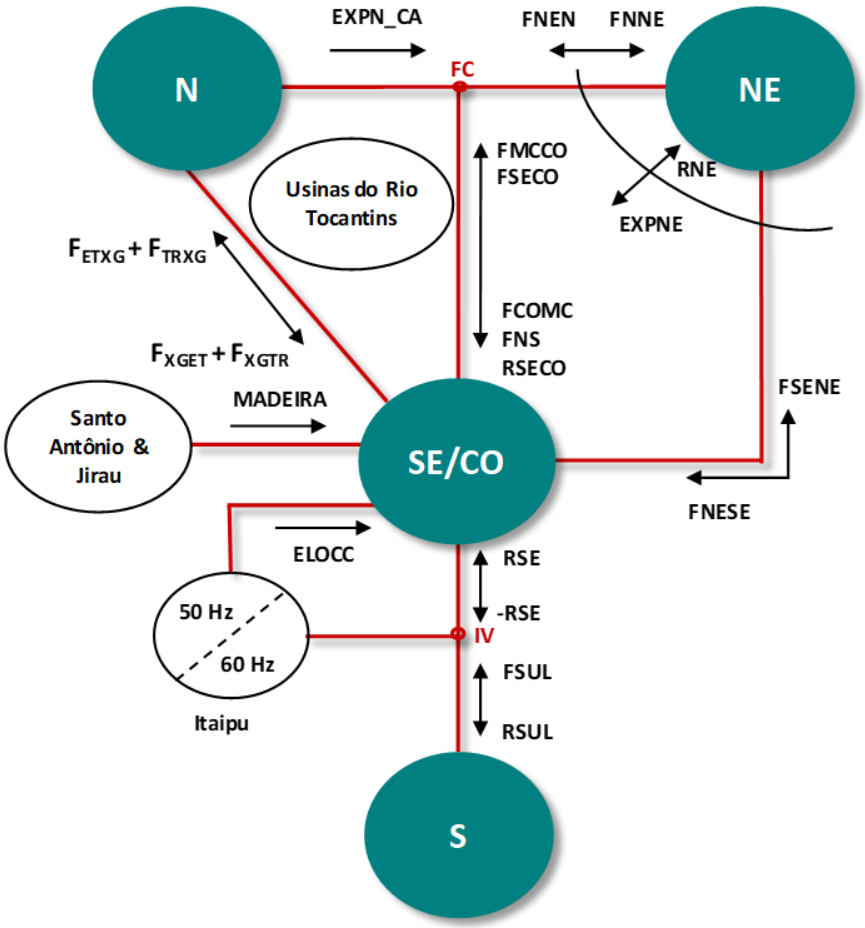

O conteúdo desta publicação foi produzido pelo ONS com base em dados e informações de conhecimento público. É de responsabilidade exclusiva dos agentes e demais interessados a obtenção de outros dados e informações, a realização de análises, estudos e avaliações para fins de tomada de decisões, definição de estratégias de atuação, assunção de compromissos e obrigações e quaisquer outras finalidades, em qualquer tempo e sob qualquer condição. É proibida a reprodução ou utilização total ou parcial do presente sem a identificação da fonte.

Tabela 4 – Limites considerados nesta semana operativa para intercâmbio de energia

Limites de Intercâmbio (MWmed)			
Fluxo	**Patamar**	**28/02 a 06/03/2026**	**Demais Semanas**
RNE	**Pesada**	11.000	11.000
	Média	11.000	11.000
	Leve	11.000	11.000
FNS	**Pesada**	3.200	3.200
	Média	3.200	3.200
	Leve	3.200	3.200
FNNE	**Pesada**	5.600	5.600
	Média	5.600	5.600
	Leve	5.600	5.600
EXPORT. NE	**Pesada**	14.700	14.700
	Média	14.700	14.700
	Leve	14.700	14.700
FMCCO	**Pesada**	5.000	5.000
	Média	5.000	5.000
	Leve	5.000	5.000
FSENE	**Pesada**	6.000	6.000
	Média	6.000	6.000
	Leve	6.000	6.000
FNS + FNESE	**Pesada**	7.488	7.488
	Média	6.504	6.504
	Leve	7.700	7.700
RSE	**Pesada**	7.445	7.445
	Média	7.445	7.445
	Leve	8.880	8.880
FORNEC. SUL	**Pesada**	7.000	7.000
	Média	7.000	7.000
	Leve	7.000	7.000

Limites de Intercâmbio (MWmed)				
Fluxo	**Patamar**	**28/02 a 06/03/2026**		**Demais Semanas**
RECEB. SUL	**Pesada**	10.450	**(A)**	10.450
	Média	6.800		6.800
	Leve	**9.388**		9.450
ELO CC 50 Hz	**Pesada**	**3.106**	**(B) (C)**	3.132
	Média	**2.889**		3.132
	Leve	**2.451**		3.132
ITAIPU 60 Hz	**Pesada**	7.500		7.500
	Média	7.500		7.500
	Leve	7.500		7.500
EXP. N CA	**Pesada**	8.000		8.000
	Média	8.000		8.000
	Leve	8.000		8.000
FETXG + FTRXG	**Pesada**	4.200		4.200
	Média	4.200		4.200
	Leve	4.200		4.200
FXGET + FXGTR	**Pesada**	8.000	**(B)**	8.000
	Média	8.000		8.000
	Leve	**7.063**		8.000
FNESE	**Pesada**	5.300		5.300
	Média	4.375		4.375
	Leve	5.300		5.300
FNEN	**Pesada**	6.000		6.000
	Média	6.000		6.000
	Leve	6.000		6.000
Ger_MADEIRA	**Pesada**	7.418	**(B)**	7.418
	Média	7.418		7.418
	Leve	**7.324**		7.418

(A) SGI 6.255-26
(B) SGI 6.589-26
(C) SGI 10.236-26

O conteúdo desta publicação foi produzido pelo ONS com base em dados e informações de conhecimento público. É de responsabilidade exclusiva dos agentes e demais interessados a obtenção de outros dados e informações, a realização de análises, estudos e avaliações para fins de tomada de decisões, definição de estratégias de atuação, assunção de compromissos e obrigações e quaisquer outras finalidades, em qualquer tempo e sob qualquer condição. É proibida a reprodução ou utilização total ou parcial do presente sem a identificação da fonte.

3.3. Previsão de carga

Em fevereiro de 2026, a confiança do empresário industrial, medida pelo ICEI (CNI), voltou a recuar e permaneceu em patamar de falta de confiança, passando de 48,5 para 48,2 pontos, o que completa 14 meses consecutivos abaixo da linha de 50 pontos. O movimento refletiu piora tanto nas condições atuais quanto nas expectativas, com destaque para a avaliação das próprias empresas, que se tornou mais negativa, e para perspectivas menos favoráveis em relação ao desempenho empresarial. Esse quadro ajuda a contextualizar, de forma complementar aos fatores meteorológicos e ao efeito Carnaval, a dinâmica da carga no período, especialmente no Subsistema Sudeste/Centro-Oeste, onde a atividade industrial tem maior peso relativo.

Com base no fechamento do PMO de Fevereiro, as projeções de carga indicam variações de 0,3% no Subsistema Sudeste/Centro-Oeste, 1,0% no Sul, 4,3% no Nordeste e -4,8% no Norte, em relação ao mesmo mês de 2025. A estimativa de fechamento da carga global na semana operativa atual (21/02 a 27/02) aponta, no Sistema Interligado Nacional (SIN), resultado 0,91% inferior ao da semana anterior (14/02 a 20/02), refletindo principalmente as reduções observadas no Sul (-4,57%) e no Sudeste/Centro-Oeste (-2,22%). No Sul, o decréscimo está associado às temperaturas mais amenas nesta semana operativa, com destaque para Curitiba. No Sudeste/Centro-Oeste, as condições meteorológicas nas capitais do Rio de Janeiro e São Paulo também influenciaram diretamente o comportamento da carga, mesmo após o efeito Carnaval observado na semana anterior. No Nordeste e no Norte, a carga registrou variações de 6,28% e 2,67%, respectivamente, indicando maior sensibilidade do Nordeste ao efeito feriado no período recente.

Para a próxima semana operativa (28/02 a 06/03), projeta-se aumento de 2,30% na carga do SIN em relação à semana atual, com expectativa de 87.364 MW médios. Esse movimento está associado à retomada da atividade econômica e à manutenção das temperaturas em capitais de maior sensibilidade, como Rio de Janeiro, São Paulo e Belo Horizonte, além de Porto Alegre, Florianópolis e Curitiba. Por fim, para março, a sinalização é de temperaturas inferiores às observadas em fevereiro na maior parte das capitais do Sul e Sudeste, e condições semelhantes nas demais regiões.

Tabela 5 – Evolução da carga do PMO de Março de 2026

Subsistema	CARGA SEMANAL (MWmed)					CARGA MENSAL (MWmed)	
	1ª Sem	2ª Sem	3ª Sem	4ª Sem	5ª Sem	mar/26	Var. (%) mar/26 -> mar/25
SE/CO	48.924	50.162	50.063	49.556	47.751	49.452	0,3%
Sul	16.075	16.077	16.028	15.675	14.354	15.752	1,0%
Nordeste	14.118	14.097	14.067	14.010	13.605	14.011	4,3%
Norte	8.248	8.281	8.252	8.234	8.085	8.232	4,8%
SIN	**87.364**	**88.617**	**88.409**	**87.474**	**83.795**	**87.447**	**1,5%**

O conteúdo desta publicação foi produzido pelo ONS com base em dados e informações de conhecimento público. É de responsabilidade exclusiva dos agentes e demais interessados a obtenção de outros dados e informações, a realização de análises, estudos e avaliações para fins de tomada de decisões, definição de estratégias de atuação, assunção de compromissos e obrigações e quaisquer outras finalidades, em qualquer tempo e sob qualquer condição. É proibida a reprodução ou utilização total ou parcial do presente sem a identificação da fonte.

3.4. Potência Hidráulica Total Disponível no SIN

O gráfico a seguir mostra a disponibilidade hidráulica total do SIN, para este mês, de acordo com o cronograma de manutenção informado pelos agentes para este PMO.

Figura 18 – Potência hidráulica disponível no SIN

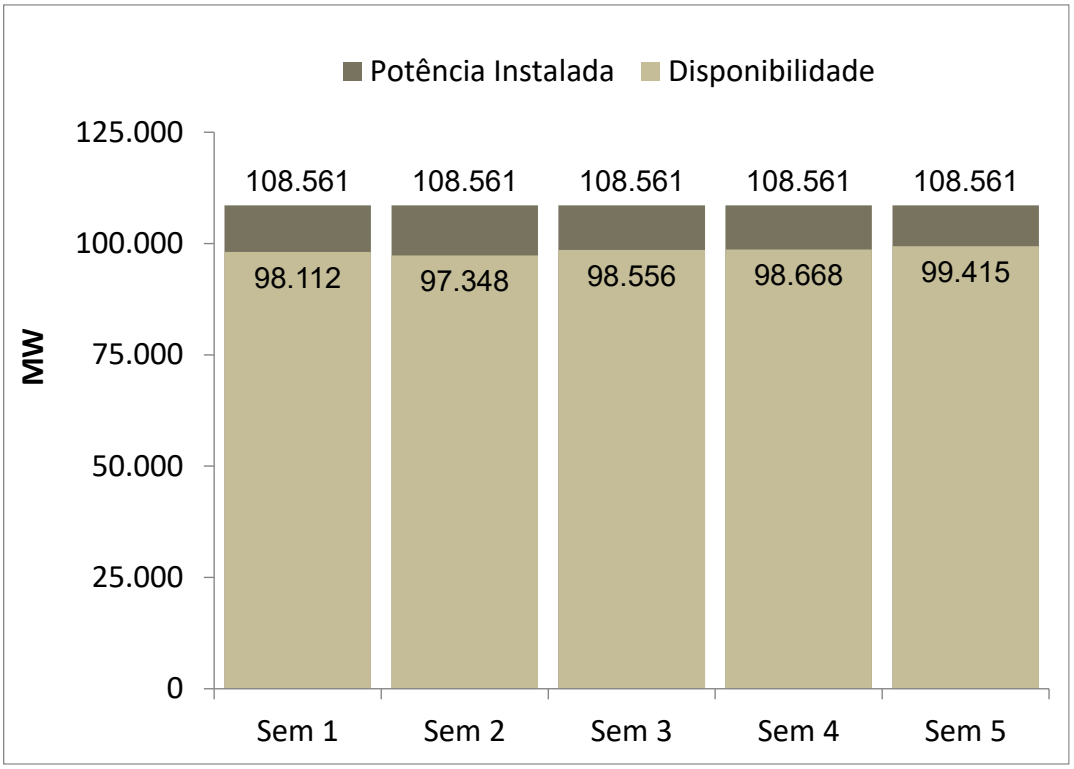

3.5. Armazenamentos Iniciais por Subsistema

Tabela 6 – Armazenamentos iniciais, por subsistema, considerados para esta semana operativa

Armazenamento (%EARmáx) - 0:00 h do dia 28/02/2026		
Subsistema	**Nível previsto na Revisão 3 do PMO Fev/2026**	**Partida informada pelos Agentes para o PMO Mar/2026**
SE/CO	57,0	56,4
S	42,7	41,2
NE	69,1	70,6
N	66,6	66,5

A primeira coluna da tabela acima corresponde ao armazenamento previsto na Revisão 3 do PMO de Fevereiro de 2026, para a 0:00 h do dia 28/02/2026. A segunda coluna apresenta os armazenamentos obtidos a partir dos níveis de partida informados pelos Agentes de Geração para seus aproveitamentos com reservatórios.

O conteúdo desta publicação foi produzido pelo ONS com base em dados e informações de conhecimento público. É de responsabilidade exclusiva dos agentes e demais interessados a obtenção de outros dados e informações, a realização de análises, estudos e avaliações para fins de tomada de decisões, definição de estratégias de atuação, assunção de compromissos e obrigações e quaisquer outras finalidades, em qualquer tempo e sob qualquer condição. É proibida a reprodução ou utilização total ou parcial do presente sem a identificação da fonte.

4. PRINCIPAIS RESULTADOS

4.1. Política de Operação Energética

Para esta semana operativa, está prevista a seguinte política de intercâmbio de energia entre regiões:

Região SE/CO:

- Geração dimensionada para controle de nível e atendimento a ponta de carga. Alocação da Folga de Potência Monitorada nas usinas dos rios Grande e Paranaíba.

Região Sul:

- Geração dimensionada para controle de nível em função das condições hidrológicas e intercâmbio. Atendimento nos períodos de carga pesada.

Região NE:

- Geração hidráulica dimensionada em função da geração das demais fontes do NE e da geração do Norte.

Região Norte:

- Exploração dos recursos em função das disponibilidades energéticas em todos os períodos de carga.

4.2. Custo Marginal de Operação – CMO

A figura a seguir apresenta os Custos Marginais de Operação, em valores médios semanais, para as semanas operativas deste mês.

Figura 19 – CMO em valores médios

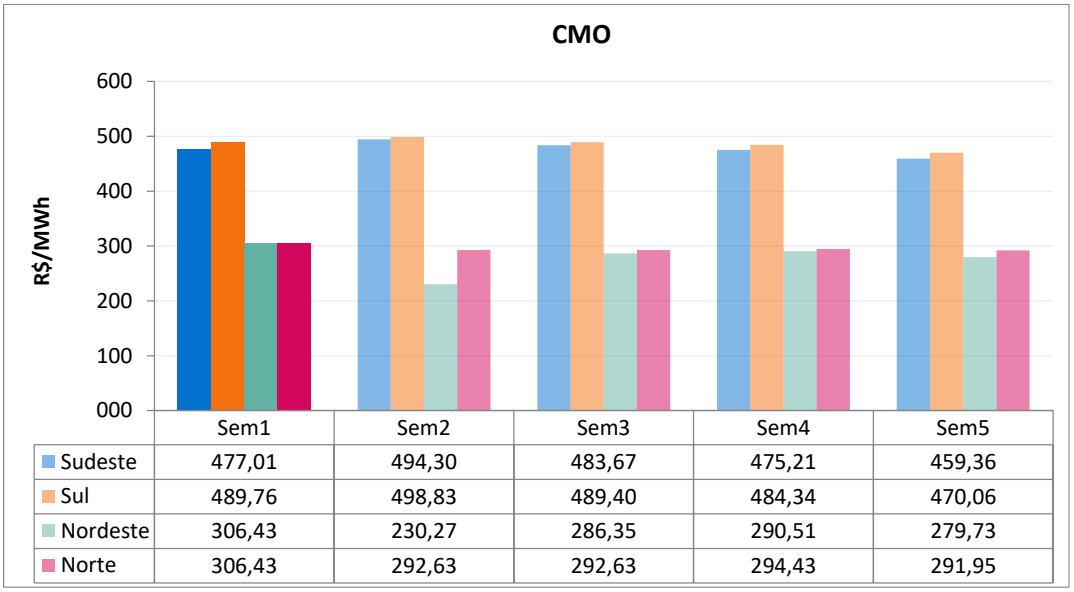

	Sem1	Sem2	Sem3	Sem4	Sem5
Sudeste	477,01	494,30	483,67	475,21	459,36
Sul	489,76	498,83	489,40	484,34	470,06
Nordeste	306,43	230,27	286,35	290,51	279,73
Norte	306,43	292,63	292,63	294,43	291,95

A tabela a seguir apresenta o custo marginal de operação, por subsistema e patamar de carga, para a próxima semana operativa.

O conteúdo desta publicação foi produzido pelo ONS com base em dados e informações de conhecimento público. É de responsabilidade exclusiva dos agentes e demais interessados a obtenção de outros dados e informações, a realização de análises, estudos e avaliações para fins de tomada de decisões, definição de estratégias de atuação, assunção de compromissos e obrigações e quaisquer outras finalidades, em qualquer tempo e sob qualquer condição. É proibida a reprodução ou utilização total ou parcial do presente sem a identificação da fonte.

Tabela 7 – CMO para esta semana operativa

Patamares de Carga	CMO (R$/MWh)			
	SE/CO	S	NE	N
Pesada	505,57	505,57	310,78	310,78
Média	476,62	505,57	305,48	305,48
Leve	464,08	464,08	305,48	305,48
Média Semanal	477,01	489,76	306,43	306,43

4.3. Energia Armazenada

O processo de otimização realizado pelo programa DECOMP indicou os armazenamentos mostrados na figura a seguir para as próximas semanas operativas do mês de março/2026.

Figura 20 – Energias Armazenadas nas semanas operativas do mês de março/2026

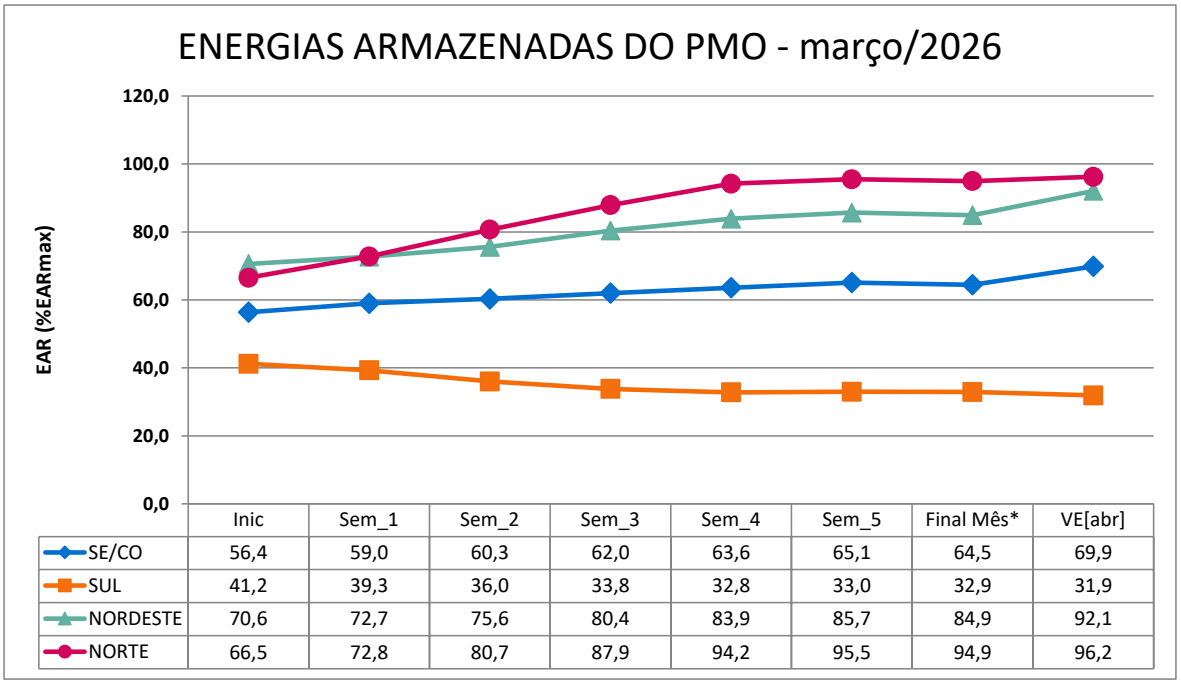

	Inic	Sem_1	Sem_2	Sem_3	Sem_4	Sem_5	Final Mês*	VE[abr]
SE/CO	56,4	59,0	60,3	62,0	63,6	65,1	64,5	69,9
SUL	41,2	39,3	36,0	33,8	32,8	33,0	32,9	31,9
NORDESTE	70,6	72,7	75,6	80,4	83,9	85,7	84,9	92,1
NORTE	66,5	72,8	80,7	87,9	94,2	95,5	94,9	96,2

Os armazenamentos da figura anterior estão expressos em percentual da Energia Armazenável Máxima de cada subsistema, que são mostradas na tabela a seguir.

Tabela 8 – Energia Armazenável Máxima por subsistema no PMO de Março/2026

ENERGIA ARMAZENÁVEL MÁXIMA (MWmed)		
Subsistema	março	abril
SE/CO	205.569	205.569
S	20.458	20.458
NE	51.718	51.718
N	15.164	14.795

O conteúdo desta publicação foi produzido pelo ONS com base em dados e informações de conhecimento público. É de responsabilidade exclusiva dos agentes e demais interessados a obtenção de outros dados e informações, a realização de análises, estudos e avaliações para fins de tomada de decisões, definição de estratégias de atuação, assunção de compromissos e obrigações e quaisquer outras finalidades, em qualquer tempo e sob qualquer condição. É proibida a reprodução ou utilização total ou parcial do presente sem a identificação da fonte.

5. GERAÇÃO TÉRMICA

A Figura 21 apresenta, para cada subsistema do SIN, o despacho térmico por modalidade indicado pelo Decomp para esta semana operativa.

Figura 21 – Geração térmica para a próxima semana operativa

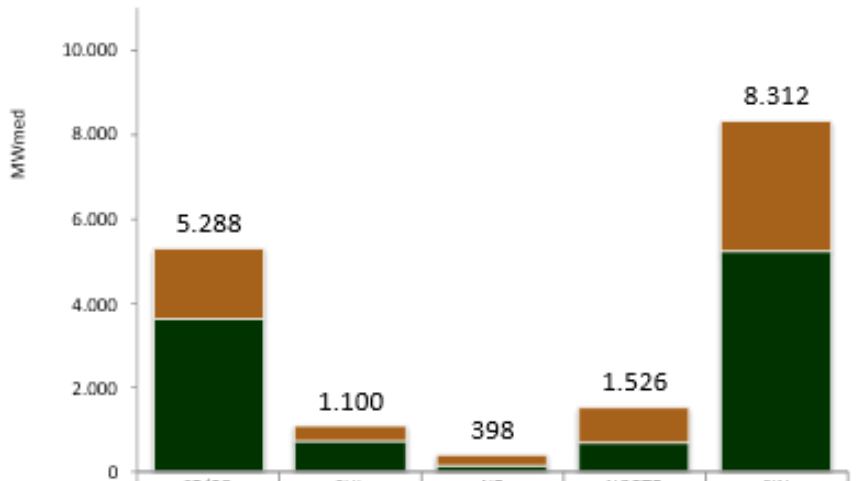

	SE/CO	SUL	NE	NORTE	SIN
TOTAL	5.288	1.100	398	1.526	8.312
ORDEM DE MÉRITO	1638	353	253	819	3063
RESTRIÇÃO ELÉTRICA	0	0	0	0	0
INFLEXIBILIDADE	3650	747	145	707	5249

O gráfico a seguir apresenta a expectativa de despacho térmico para os dois meses do horizonte de estudo.

Figura 22 – Expectativa de despacho térmico para o horizonte de dois meses

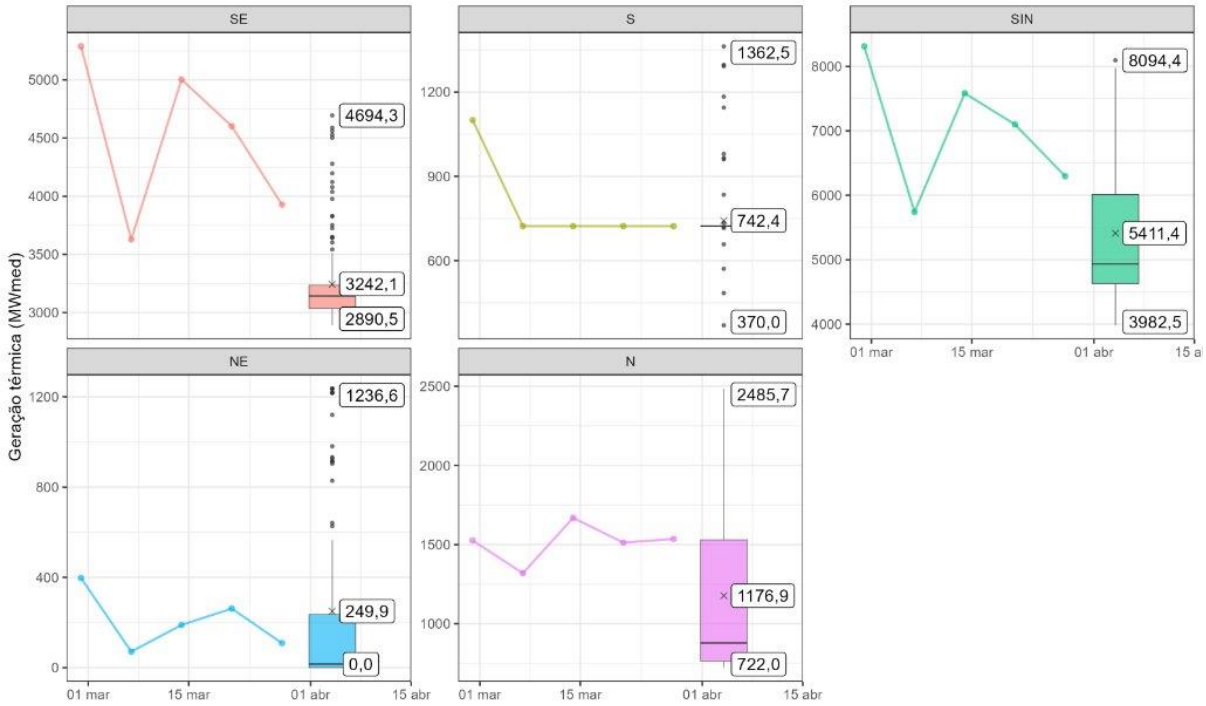

O conteúdo desta publicação foi produzido pelo ONS com base em dados e informações de conhecimento público. É de responsabilidade exclusiva dos agentes e demais interessados a obtenção de outros dados e informações, a realização de análises, estudos e avaliações para fins de tomada de decisões, definição de estratégias de atuação, assunção de compromissos e obrigações e quaisquer outras finalidades, em qualquer tempo e sob qualquer condição. É proibida a reprodução ou utilização total ou parcial do presente sem a identificação da fonte.

Na tabela abaixo segue a Indicação de despacho antecipado por ordem de mérito de custo para a semana de 02/05/2026 a 08/05/2026.

Tabela 9 – UTEs com contrato de combustível GNL

UTE			Benefício (R$/MWh)			Despacho antecipado por mérito		
Nome	Código	CVU (R$/MWh)	Carga Pesada	Carga Média	Carga Leve	Carga Pesada	Carga Média	Carga Leve
SANTA CRUZ	86	488,96	255,46	246,49	221,91	Não	Não	Não
PSERGIPE I	224	311,29	230,22	218,67	217,58	Não	Não	Não

Assim sendo, não há previsão de despacho antecipado por ordem de mérito de custo para as UTE Santa Cruz e Porto Sergipe I, para a semana de 02/05/2026 a 08/05/2026.

O conteúdo desta publicação foi produzido pelo ONS com base em dados e informações de conhecimento público. É de responsabilidade exclusiva dos agentes e demais interessados a obtenção de outros dados e informações, a realização de análises, estudos e avaliações para fins de tomada de decisões, definição de estratégias de atuação, assunção de compromissos e obrigações e quaisquer outras finalidades, em qualquer tempo e sob qualquer condição. É proibida a reprodução ou utilização total ou parcial do presente sem a identificação da fonte.

6. RESUMO DOS RESULTADOS DO PMO

As figuras a seguir apresentam um resumo dos resultados do PMO de Março/2026, com informações da Energia Natural Afluente (ENA), da Energia Armazenada (EAR) e do Custo Marginal de Operação (CMO) nos subsistemas do Sistema Interligado Nacional (SIN). São apresentados os valores semanais observados e previstos e o valor esperado dos cenários gerados para o mês de abril/2026.

Figura 23 – Resumo de março/2026 para o Subsistema Sudeste/Centro-Oeste

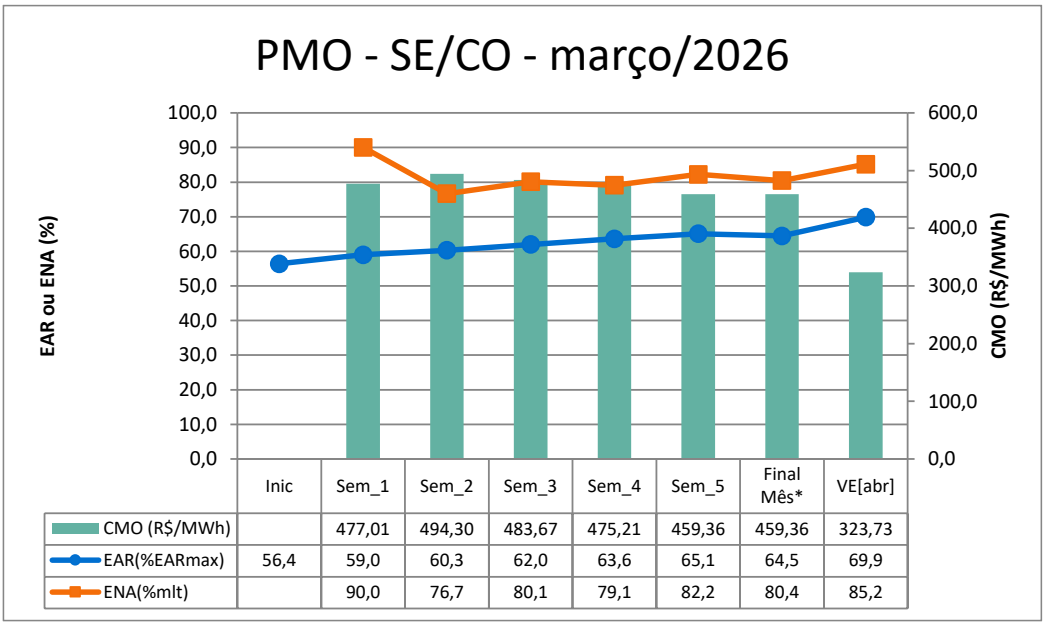

	Inic	Sem_1	Sem_2	Sem_3	Sem_4	Sem_5	Final Mês*	VE[abr]
CMO (R$/MWh)		477,01	494,30	483,67	475,21	459,36	459,36	323,73
EAR(%EARmax)	56,4	59,0	60,3	62,0	63,6	65,1	64,5	69,9
ENA(%mlt)		90,0	76,7	80,1	79,1	82,2	80,4	85,2

Figura 24 – Resumo de março/2026 para o Subsistema Sul

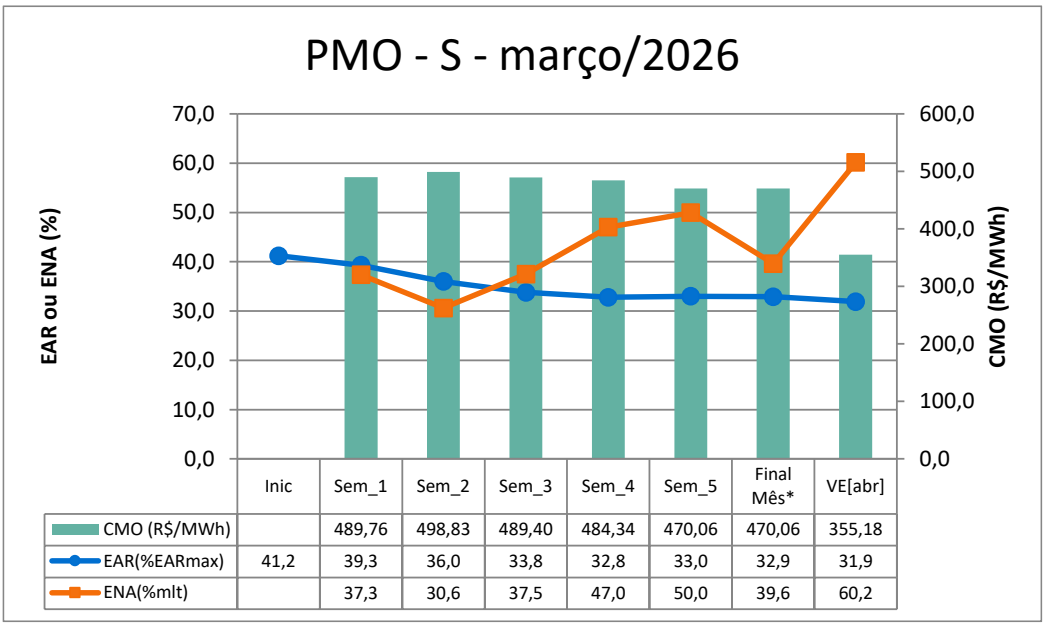

	Inic	Sem_1	Sem_2	Sem_3	Sem_4	Sem_5	Final Mês*	VE[abr]
CMO (R$/MWh)		489,76	498,83	489,40	484,34	470,06	470,06	355,18
EAR(%EARmax)	41,2	39,3	36,0	33,8	32,8	33,0	32,9	31,9
ENA(%mlt)		37,3	30,6	37,5	47,0	50,0	39,6	60,2

O conteúdo desta publicação foi produzido pelo ONS com base em dados e informações de conhecimento público. É de responsabilidade exclusiva dos agentes e demais interessados a obtenção de outros dados e informações, a realização de análises, estudos e avaliações para fins de tomada de decisões, definição de estratégias de atuação, assunção de compromissos e obrigações e quaisquer outras finalidades, em qualquer tempo e sob qualquer condição. É proibida a reprodução ou utilização total ou parcial do presente sem a identificação da fonte.

Figura 25 – Resumo de março/2026 para o Subsistema Nordeste

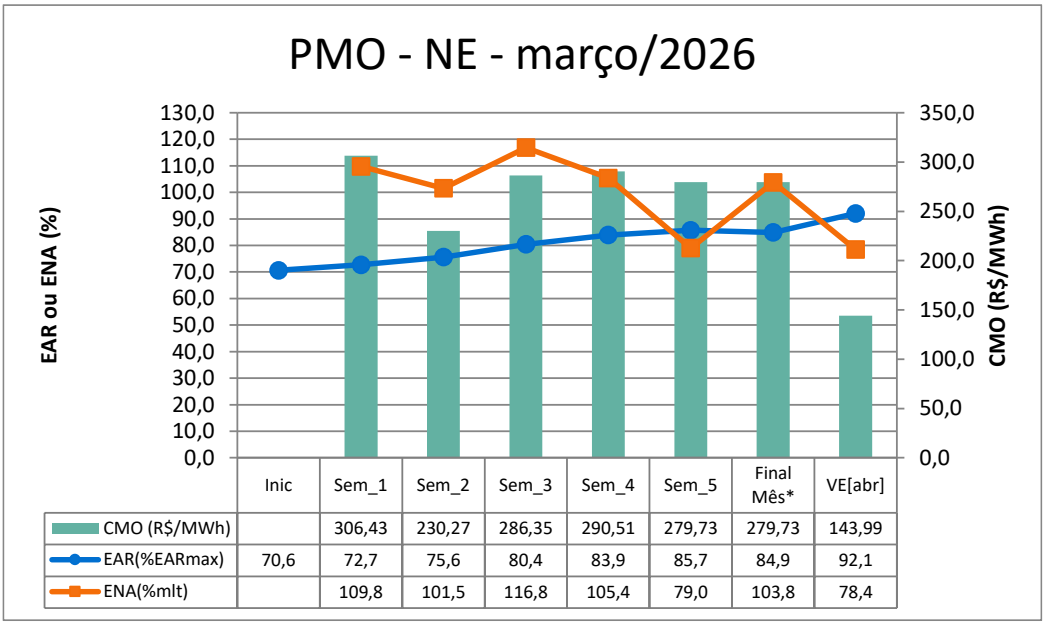

	Inic	Sem_1	Sem_2	Sem_3	Sem_4	Sem_5	Final Mês*	VE[abr]
CMO (R$/MWh)		306,43	230,27	286,35	290,51	279,73	279,73	143,99
EAR(%EARmax)	70,6	72,7	75,6	80,4	83,9	85,7	84,9	92,1
ENA(%mlt)		109,8	101,5	116,8	105,4	79,0	103,8	78,4

Figura 26 – Resumo de março/2026 para o Subsistema Norte

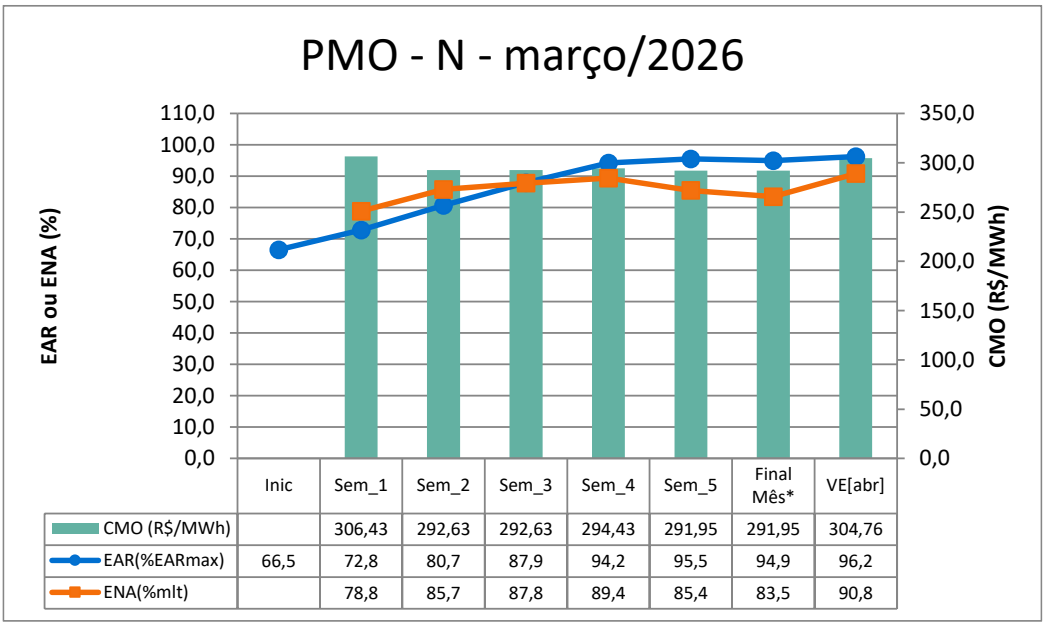

	Inic	Sem_1	Sem_2	Sem_3	Sem_4	Sem_5	Final Mês*	VE[abr]
CMO (R$/MWh)		306,43	292,63	292,63	294,43	291,95	291,95	304,76
EAR(%EARmax)	66,5	72,8	80,7	87,9	94,2	95,5	94,9	96,2
ENA(%mlt)		78,8	85,7	87,8	89,4	85,4	83,5	90,8

O conteúdo desta publicação foi produzido pelo ONS com base em dados e informações de conhecimento público. É de responsabilidade exclusiva dos agentes e demais interessados a obtenção de outros dados e informações, a realização de análises, estudos e avaliações para fins de tomada de decisões, definição de estratégias de atuação, assunção de compromissos e obrigações e quaisquer outras finalidades, em qualquer tempo e sob qualquer condição. É proibida a reprodução ou utilização total ou parcial do presente sem a identificação da fonte.

7. ARMAZENAMENTOS OPERATIVOS

Para uma melhor avaliação de diversos cenários hidrometeorológicos, notadamente, aqueles de curto prazo e suas influências nas previsões de vazões nos subsistemas, os resultados deste PMO contemplam cenários de afluências visando melhor representar a ocorrência de precipitação e, consequentemente, seus efeitos sobre as afluências e armazenamentos.

Apresentamos a seguir as correspondentes energias naturais afluentes e os resultados obtidos com a aplicação do cenário de afluência utilizado no estudo.

Tabela 10 – Previsão de ENA do caso de valor esperado das previsões de afluência

Subsistema	ENERGIAS NATURAIS AFLUENTES			
	Previsão Semanal		Previsão Mensal	
	(MWmed)	%MLT	(MWmed)	%MLT
SE/CO	62.433	90	55.560	80
Sul	2.715	37	2.816	40
Nordeste	15.423	110	14.548	104
Norte	21.277	81	22.448	83

Tabela 11 – Previsão de %EARmáx para o final do mês

Subsistema	% EARmáx 27/02	% EARmáx - 31/03
	NÍVEL INICIAL	NÍVEL PMO
SE/CO	56,4	64,5
Sul	41,2	32,9
Nordeste	70,6	84,9
Norte	66,5	94,9

O conteúdo desta publicação foi produzido pelo ONS com base em dados e informações de conhecimento público. É de responsabilidade exclusiva dos agentes e demais interessados a obtenção de outros dados e informações, a realização de análises, estudos e avaliações para fins de tomada de decisões, definição de estratégias de atuação, assunção de compromissos e obrigações e quaisquer outras finalidades, em qualquer tempo e sob qualquer condição. É proibida a reprodução ou utilização total ou parcial do presente sem a identificação da fonte.

8. RESERVATÓRIOS EQUIVALENTES DE ENERGIA

A seguir são apresentadas as previsões de Energia Natural Afluente para a próxima semana operativa e para o mês de março, bem como as previsões de Energia Armazenada nos Reservatórios Equivalentes de Energia – REE, deste PMO de Março de 2026.

Tabela 12 – Previsão de ENA por REE

Valor Esperado das Energias Naturais Afluentes				
REE	Previsão Semanal		Previsão Mensal	
	28/02/2026 a 06/03/2026		mar-26	
	(MWmed)	%MLT	(MWmed)	%MLT
Sudeste	13.073	130	8.592	86
Madeira	10.269	86	11.589	96
Teles Pires	5.119	122	5.566	131
Itaipu	2.579	67	2.454	64
Paraná	30.047	83	25.861	72
Paranapanema	1.328	41	1.485	47
Sul	1.383	42	1.446	45
Iguaçu	1.332	34	1.370	35
Nordeste	15.423	110	14.548	104
Norte	12.947	89	12.070	81
Belo Monte	7.026	67	9.788	91
Manaus	760	66	1.099	92

Tabela 13 – Previsão de %EARmáx por REE

% Energia Armazenável Máxima		
REE	Previsão Semanal	Previsão Mensal
	06-mar	31-mar
	(%EARmáx)	(%EARmáx)
Sudeste	60,6	63,9
Madeira	91,4	100,0
Teles Pires	51,0	98,0
Itaipu	40,6	6,0
Paraná	59,2	66,7
Paranapanema	51,2	40,6
Sul	48,4	33,8
Iguaçu	30,4	32,1
Nordeste	72,7	84,9
Norte	74,4	97,7
Belo Monte	42,9	99,8
Manaus	45,0	44,4

O conteúdo desta publicação foi produzido pelo ONS com base em dados e informações de conhecimento público. É de responsabilidade exclusiva dos agentes e demais interessados a obtenção de outros dados e informações, a realização de análises, estudos e avaliações para fins de tomada de decisões, definição de estratégias de atuação, assunção de compromissos e obrigações e quaisquer outras finalidades, em qualquer tempo e sob qualquer condição. É proibida a reprodução ou utilização total ou parcial do presente sem a identificação da fonte.

9. DESPACHO TÉRMICO POR MODALIDADE, PATAMAR DE CARGA E USINA

Nas tabelas abaixo, a diferenciação entre geração por inflexibilidade e por ordem de mérito tem caráter informativo, com o objetivo de detalhar a informação de inflexibilidade enviada pelos respectivos agentes para o PMO. Ressalta-se que nas etapas de Programação Diária e Tempo Real, o montante despachado nas usinas termelétricas indicadas por ordem de mérito é plenamente intitulado como ordem de mérito.

REGIÃO SUDESTE/CENTRO-OESTE																	
Térmicas Potência (MW)	Combustível	CVU (R$/MWh)	Inflexibilidade			Ordem de Mérito			Total Mérito e INFL.			Razão Elétrica			Total UTE		
			P	M	L	P	M	L	P	M	L	P	M	L	P	M	L
ATLANTICO (490)	Resíduos	0,00	378,9	378,9	378,9				378,9	378,9	378,9				378,9	378,9	378,9
DAIA (44)	Diesel	---															
PALMEIR_GO (176)	Diesel	---															
PAULINIA (16)	Gás	---															
TNORTE 2 (349)	Óleo	---															
W.ARJONA O (177)	Diesel	---															
XAVANTES (54)	Diesel	---															
ANGRA 2 (1350)	Nuclear	20,12				0,0	0,0	0,0									
ANGRA 1 (640)	Nuclear	31,17	460,0	460,0	460,0	0,0	0,0	0,0	460,0	460,0	460,0				460,0	460,0	460,0
M.AZUL (566)	Gás	133,71	495,0	495,0	495,0	70,5	70,5	70,5	565,5	565,5	565,5				565,5	565,5	565,5
O.PINTADA (50)	Biomassa	152,33				50,0	50,0	50,0	50,0	50,0	50,0				50,0	50,0	50,0
UTE STA VI (41)	Biomassa	164,56				0,0	0,0	0,0									
ST.CRUZ 34 (436)	Óleo	310,41				0,0	0,0	0,0									
CUBATAO (216)	Gás	356,45	205,0	205,0	205,0	11,0	11,0	11,0	216,0	216,0	216,0				216,0	216,0	216,0
UTE GNA II (1673)	Gás	464,08				1673,0	1673,0	1231,8	1673,0	1673,0	1231,8				1673,0	1673,0	1231,8
BAIXADA FL (530)	Gás	482,92	520,0	520,0	520,0	10,0			530,0	520,0	520,0				530,0	520,0	520,0
SANTA CRUZ (500)	GNL	488,96															
KARKEY 013 (259)	Gás	730,80	31,0	31,0	31,0				31,0	31,0	31,0				31,0	31,0	31,0
KARKEY 019 (116)	Gás	730,80															
T.LAGOAS (350)	Gás	825,23	302,0	301,9	286,9				302,0	301,9	286,9				302,0	301,9	286,9
CUIABA CC (529)	Gás	859,98															
PORSUD I (116)	Gás	862,73															
PORSUD II (78)	Gás	864,22															
W.ARJONA (177)	Gás	874,61															
IBIRITE (226)	Gás	874,88															
TERMORIO (989)	Gás	876,22	480,0	470,3	393,8				480,0	470,3	393,8				480,0	470,3	393,8
LUIZORMELO (204)	Gás	941,79	32,0	5,0					32,0	5,0					32,0	5,0	0,0
UTE GNA I (1338)	Gás	956,16															
NORTEFLU (826)	Gás	975,58															
POVOACAO I (75)	Gás	986,05	62,0	5,0					62,0	5,0					62,0	5,0	0,0
VIANA (175)	Óleo	990,61															
T.MACAE (922)	Gás	1066,66	702,0	306,5	354,4				702,0	306,5	354,4				702,0	306,5	354,4
VIANA I (37)	Gás	1124,32	32,0	5,0					32,0	5,0					32,0	5,0	0,0
SEROPEDICA (360)	Gás	1136,90	288,0	124,1	129,4				288,0	124,1	129,4				288,0	124,1	129,4
J.FORA (87)	Gás	1146,82	84,0	28,4	36,8				84,0	28,4	36,8				84,0	28,4	36,8
NPIRATINGA (572)	Gás	1379,23	380,0	151,5	170,7				380,0	151,5	170,7				380,0	151,5	170,7
TOTAL SE/CO (14744)			4451,9	3487,6	3461,9	1814,5	1804,5	1363,3	6266,4	5292,1	4825,2	0,0	0,0	0,0	6266,4	5292,1	4825,2

REGIÃO SUL																	
Térmicas Potência (MW)	Combustível	CVU (R$/MWh)	Inflexibilidade			Ordem de Mérito			Total Mérito e INFL.			Razão Elétrica			Total UTE		
			P	M	L	P	M	L	P	M	L	P	M	L	P	M	L
B.BONITA I (10)	Gás	---															
PAMPA SUL (345)	Carvão	105,94				345,0	345,0	345,0	345,0	345,0	345,0				345,0	345,0	345,0
SAO SEPE (8)	Biomassa	118,84				8,0	8,0	8,0	8,0	8,0	8,0				8,0	8,0	8,0
J.LACER. C (330)	Carvão	347,20		31,0	88,0	0,0	0,0	0,0		31,0	88,0				0,0	31,0	88,0
J.LACER. B (220)	Carvão	406,71	220,0	220,0	220,0	0,0	0,0	0,0	220,0	220,0	220,0				220,0	220,0	220,0
J.LAC. A2 (110)	Carvão	416,39	110,0	110,0	110,0	0,0	0,0	0,0	110,0	110,0	110,0				110,0	110,0	110,0
J.LAC. A1 (80)	Carvão	518,90	40,0	40,0	40,0				40,0	40,0	40,0				40,0	40,0	40,0
CANDIOTA_3 (350)	Carvão	519,16	330,0	330,0	330,0				330,0	330,0	330,0				330,0	330,0	330,0
ARAUCARIA (484)	Gás	900,00															
URUGUAIANA (640)	Gás	1268,92															
CANOAS (249)	Gás	1374,17															
TOTAL SUL (2826)			700,0	731,0	788,0	353,0	353,0	353,0	1053,0	1084,0	1141,0	0,0	0,0	0,0	1053,0	1084,0	1141,0

O conteúdo desta publicação foi produzido pelo ONS com base em dados e informações de conhecimento público. É de responsabilidade exclusiva dos agentes e demais interessados a obtenção de outros dados e informações, a realização de análises, estudos e avaliações para fins de tomada de decisões, definição de estratégias de atuação, assunção de compromissos e obrigações e quaisquer outras finalidades, em qualquer tempo e sob qualquer condição. É proibida a reprodução ou utilização total ou parcial do presente sem a identificação da fonte.

REGIÃO NORDESTE

Térmicas Potência (MW)	Combustível	CVU (R$/MWh)	Inflexibilidade			Ordem de Mérito			Total Mérito e INFL.			Razão Elétrica			Total UTE		
			P	M	L	P	M	L	P	M	L	P	M	L	P	M	L
MARACANAU (168)	Óleo	---															
PETROLINA (136)	Óleo	---															
ERB CANDEI (17)	Biomassa	118,93				12,0	12,0	12,0	12,0	12,0	12,0				12,0	12,0	12,0
PROSP_I (28)	Gás	224,31				18,7	18,7	18,7	18,7	18,7	18,7				18,7	18,7	18,7
PROSP_III (56)	Gás	228,55				56,0	56,0	56,0	56,0	56,0	56,0				56,0	56,0	56,0
PROSP_II (37)	Gás	280,49				37,3	37,3	37,3	37,3	37,3	37,3				37,3	37,3	37,3
P.PECEM1 (720)	Carvão	308,16				720,0			720,0						720,0	0,0	0,0
PSERGIPE I (1593)	GNL	311,29															
P.PECEM2 (365)	Carvão	318,91															
VALE ACU (110)	Gás	450,86	22,0	16,4	22,3				22,0	16,4	22,3				22,0	16,4	22,3
PERNAMBU_3 (201)	Óleo	753,06															
TERMOPE (550)	Gás	826,55															
SUAPE II (381)	Óleo	890,08															
T.BAHIA (186)	Gás	1024,43	109,0	119,6	138,8				109,0	119,6	138,8				109,0	119,6	138,8
GLOBAL I (136)	Óleo	1120,77															
GLOBAL II (136)	Óleo	1120,77															
TERMOCABO (50)	Óleo	1495,67															
TERMONE (171)	Óleo	1831,39															
TERMOPB (171)	Óleo	1831,39															
POTIGUAR (53)	Diesel	1841,86															
POTIGUAR_3 (66)	Diesel	1841,86															
CAMPINA_GR (169)	Óleo	2076,29															
TERMOCEARA (223)	Óleo	2244,40															
C.MURICY 2 (144)	Óleo	2301,01															
PECEM 2 (144)	Óleo	2324,95															
TOTAL NE (5725)			131,0	136,0	161,1	844,0	124,0	124,0	975,0	260,0	285,1	0,0	0,0	0,0	975,0	260,0	285,1

REGIÃO NORTE

Térmicas Potência (MW)	Combustível	CVU (R$/MWh)	Inflexibilidade			Ordem de Mérito			Total Mérito e INFL.			Razão Elétrica			Total UTE		
			P	M	L	P	M	L	P	M	L	P	M	L	P	M	L
MARANHAO3 (519)	Gás	116,10				499,6	505,5	511,6	499,6	505,5	511,6				499,6	505,5	511,6
APARECIDA (166)	Gás	213,34	90,0	90,0	90,0	27,0	27,0	27,0	117,0	117,0	117,0				117,0	117,0	117,0
JARAQUI (75)	Gás	213,34	49,3	49,3	49,3	13,7	13,7	13,7	63,0	63,0	63,0				63,0	63,0	63,0
PIRARUCU (73)	Gás	213,34	66,0	66,0	66,0	1,0	1,0	1,0	67,0	67,0	67,0				67,0	67,0	67,0
PORAQUE (85)	Gás	213,34	49,5	49,5	49,5	18,5	18,5	18,5	68,0	68,0	68,0				68,0	68,0	68,0
TAMBAQUI (93)	Gás	213,34	56,0	56,0	56,0	7,0	7,0	7,0	63,0	63,0	63,0				63,0	63,0	63,0
TUCUNARE (73)	Gás	213,34	66,0	66,0	66,0	0,0	0,0	0,0	66,0	66,0	66,0				66,0	66,0	66,0
UTE MAUA 3 (591)	Gás	213,34	264,0	264,0	264,0	10,0	10,0	10,0	274,0	274,0	274,0				274,0	274,0	274,0
PARNAIBA_V (386)	Vapor	226,34				0,0	0,0	0,0									
JAGUATI II (141)	Gás	289,25				126,2	126,2	126,2	126,2	126,2	126,2				126,2	126,2	126,2
N.VENECIA2 (270)	Gás	308,35				259,9			259,9						259,9	0,0	0,0
P. ITAQUI (360)	Carvão	310,78				348,1			348,1						348,1	0,0	0,0
MARANHAO V (338)	Gás	446,77															
MARANHAOIV (338)	Gás	446,77															
BONFIM (12)	Biomassa	555,69	5,0	5,0	5,0				5,0	5,0	5,0				5,0	5,0	5,0
CANTA (12)	Biomassa	555,69	5,0	5,0	5,0				5,0	5,0	5,0				5,0	5,0	5,0
PAU RAINHA (12)	Biomassa	555,69	5,0	5,0	5,0				5,0	5,0	5,0				5,0	5,0	5,0
SANTA LUZ (12)	Biomassa	555,69	5,0	5,0	5,0				5,0	5,0	5,0				5,0	5,0	5,0
PARNAIB_IV (56)	Gás	788,17	37,0	41,0	44,0				37,0	41,0	44,0				37,0	41,0	44,0
BBF BALIZA (18)	Biomassa	876,44	5,0	5,0	5,0				5,0	5,0	5,0				5,0	5,0	5,0
GERAMAR1 (166)	Óleo	913,46															
GERAMAR2 (166)	Óleo	913,46															
M.C.SUCUBA (42)	Diesel	1679,44															
PALMAPLAN (12)	Biomassa	1773,63															
TOTAL NORTE (4303)			702,8	706,8	709,8	1311,0	708,9	715,0	2013,8	1415,7	1424,8	0,0	0,0	0,0	2013,8	1415,7	1424,8

O conteúdo desta publicação foi produzido pelo ONS com base em dados e informações de conhecimento público. É de responsabilidade exclusiva dos agentes e demais interessados a obtenção de outros dados e informações, a realização de análises, estudos e avaliações para fins de tomada de decisões, definição de estratégias de atuação, assunção de compromissos e obrigações e quaisquer outras finalidades, em qualquer tempo e sob qualquer condição. É proibida a reprodução ou utilização total ou parcial do presente sem a identificação da fonte.