1. APRESENTAÇÃO

O mês de agosto foi marcado por precipitação nas bacias dos rios Uruguai, Jacuí, Taquari-Antas, Iguaçu e na incremental a UHE Itaipu, com acumulado mensal de precipitação acima da média nas bacias dos rios Uruguai, Iguaçu e na incremental a UHE Itaipu

Na semana de 23/08 a 29/08/2025 houve precipitação nas bacias dos rios Uruguai, Jacuí, Taquari-Antas, Iguaçu e incremental a UHE Itaipu, com totais entre a média e acima da média semanal. Para as demais bacias hidrográficas de interesse do SIN permaneceu a condição de estiagem

Na semana de 30/08 a 05/09/2025 deve ocorrer precipitação nas bacias dos rios Jacuí e Uruguai, , com totais entre a média e abaixo da média semanal. Nas demais bacias hidrográficas de interesse do SIN não há previsão de precipitação significativa.

Os valores médios semanais do Custo Marginal de Operação – CMO dos subsistemas do SIN sofreram as seguintes alterações em relação à semana anterior:

- SE/CO: de R$ 332,02/MWh para R$ 299,76/MWh
- Sul: de R$ 332,02/MWh para R$ 299,76/MWh
- Nordeste: de R$ 332,02/MWh para R$ 299,76/MWh
- Norte: de R$ 332,02/MWh para R$ 299,76/MWh

Desde o dia 01/01/2020, o despacho por ordem de mérito é indicado diariamente pelos resultados do modelo DESSEM. Assim, o despacho por ordem de mérito semanal, conforme publicado nesse documento, tem caráter apenas informativo. Da mesma forma, desde o dia 01/01/2021, a formação de preço deixou o formato semanal/patamar de carga e passou a ser horário, de acordo também com os resultados do modelo DESSEM.

2. NOTÍCIAS

Nos dias 25 e 26 de setembro será realizada a reunião de elaboração do PMO de Outubro de 2025, com transmissão ao vivo através do site do ONS.

3. INFORMAÇÕES CONJUNTURAIS PARA ELABORAÇÃO DO PMO

3.1. Informações hidrometeorológicas

3.1.1. Condições antecedentes

O mês de agosto foi marcado pela passagem de frentes frias mais restrita a Região Sul, ocasionando precipitação nas bacias dos rios Uruguai, Jacuí, Taquari-Antas, Iguaçu e na incremental a UHE Itaipu. Com essa configuração, o acumulado mensal de precipitação esteve acima da média nas bacias dos rios Uruguai, Iguaçu e na incremental a UHE Itaipu (Figura 1).

O conteúdo desta publicação foi produzido pelo ONS com base em dados e informações de conhecimento público. É de responsabilidade exclusiva dos agentes e demais interessados a obtenção de outros dados e informações, a realização de análises, estudos e avaliações para fins de tomada de decisões, definição de estratégias de atuação, assunção de compromissos e obrigações e quaisquer outras finalidades, em qualquer tempo e sob qualquer condição. É proibida a reprodução ou utilização total ou parcial do presente sem a identificação da fonte.

Figura 1 - Mapa de anomalia da precipitação acumulada (mm) – Agosto/2025

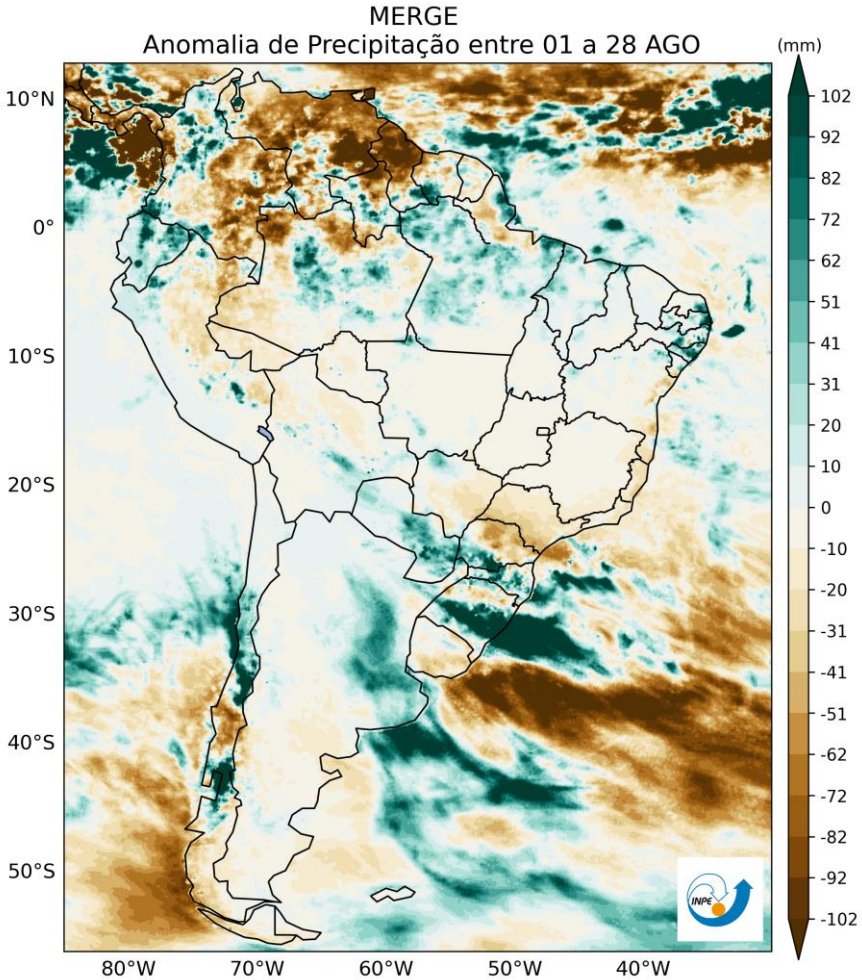

No início da semana operativa, a passagem de uma frente fria ocasionou precipitação nas bacias dos rios Uruguai, Jacuí, Taquari-Antas, Iguaçu e incremental a UHE Itaipu, com totais entre a média e acima da média semanal. Para as demais bacias hidrográficas de interesse do SIN permaneceu a condição de estiagem (Figura 2).

O conteúdo desta publicação foi produzido pelo ONS com base em dados e informações de conhecimento público. É de responsabilidade exclusiva dos agentes e demais interessados a obtenção de outros dados e informações, a realização de análises, estudos e avaliações para fins de tomada de decisões, definição de estratégias de atuação, assunção de compromissos e obrigações e quaisquer outras finalidades, em qualquer tempo e sob qualquer condição. É proibida a reprodução ou utilização total ou parcial do presente sem a identificação da fonte.

Figura 2 - Precipitação observada (mm) no período de 23 a 28/08/2025

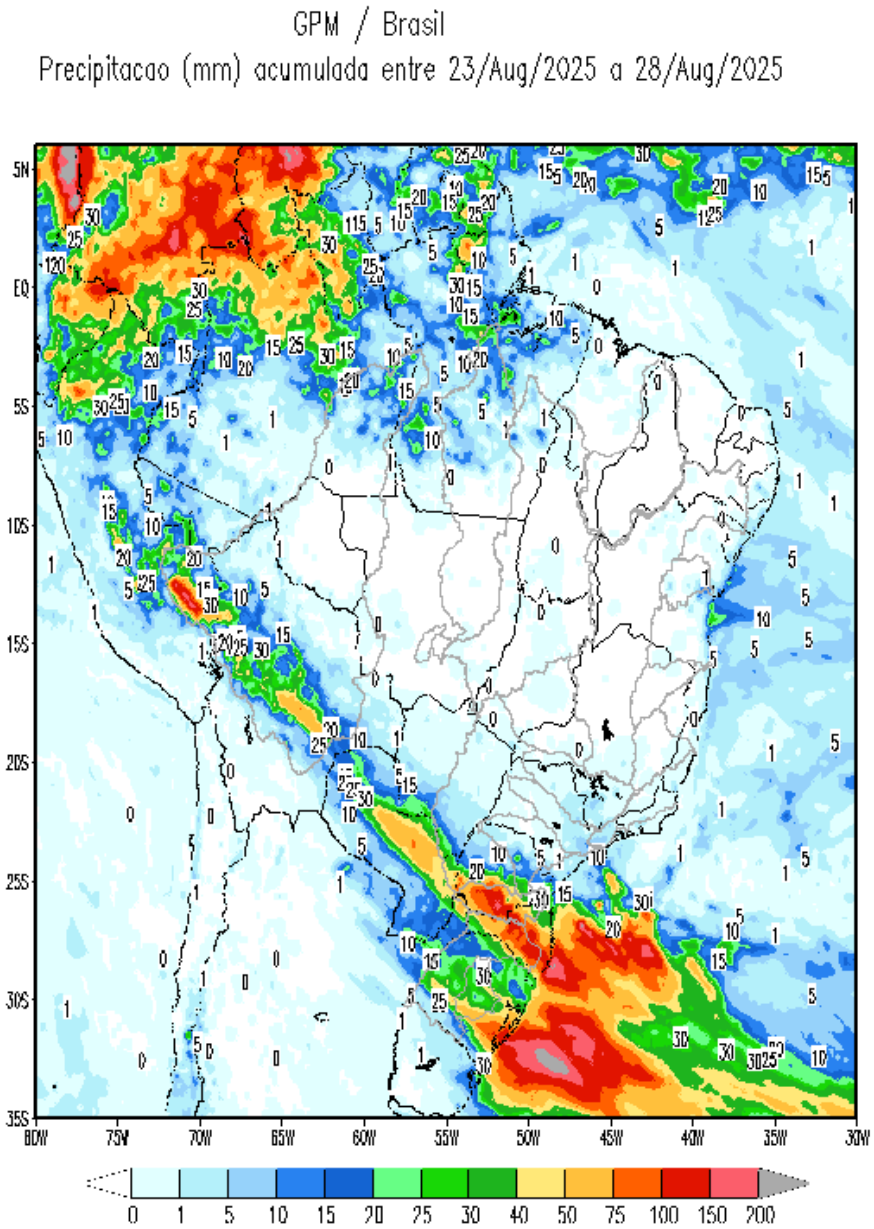

A Tabela 1 apresenta as energias naturais afluentes das semanas recentes. São apresentados os valores verificados na semana 16/08/2025 a 22/08/2025 e os estimados para fechamento da semana de 23/08/2025 a 29/08/2025.

Tabela 1 – Tendência hidrológica da ENA do PMO de Setembro/2025

PMO de Setembro/2025 - ENAs verificadas e estimadas				
Subsistema	16/08 a 22/08/2025		23/08 a 29/08/2025	
	MWmed	%MLT	MWmed	%MLT
SE/CO	14.000	68	12.961	63
S	5.474	55	18.249	183
NE	1.386	42	1.352	41
N	2.155	68	1.848	58

O conteúdo desta publicação foi produzido pelo ONS com base em dados e informações de conhecimento público. É de responsabilidade exclusiva dos agentes e demais interessados a obtenção de outros dados e informações, a realização de análises, estudos e avaliações para fins de tomada de decisões, definição de estratégias de atuação, assunção de compromissos e obrigações e quaisquer outras finalidades, em qualquer tempo e sob qualquer condição. É proibida a reprodução ou utilização total ou parcial do presente sem a identificação da fonte.

3.1.2. Climatologia para o trimestre setembro-outubro-novembro de 2025

Para o trimestre setembro-outubro-novembro (SON) de 2025, o cenário mais provável é de precipitação entre normal e abaixo da média na Região Sul, e próximo da média nas demais bacias hidrográficas do SIN.

Climatologicamente, nesse trimestre os maiores totais de precipitação são observados no oeste da Região Norte e nas bacias hidrográficas da Região Sul (Figura 3).

Figura 3 - Climatologia de precipitação para o trimestre setembro-outubro-novembro

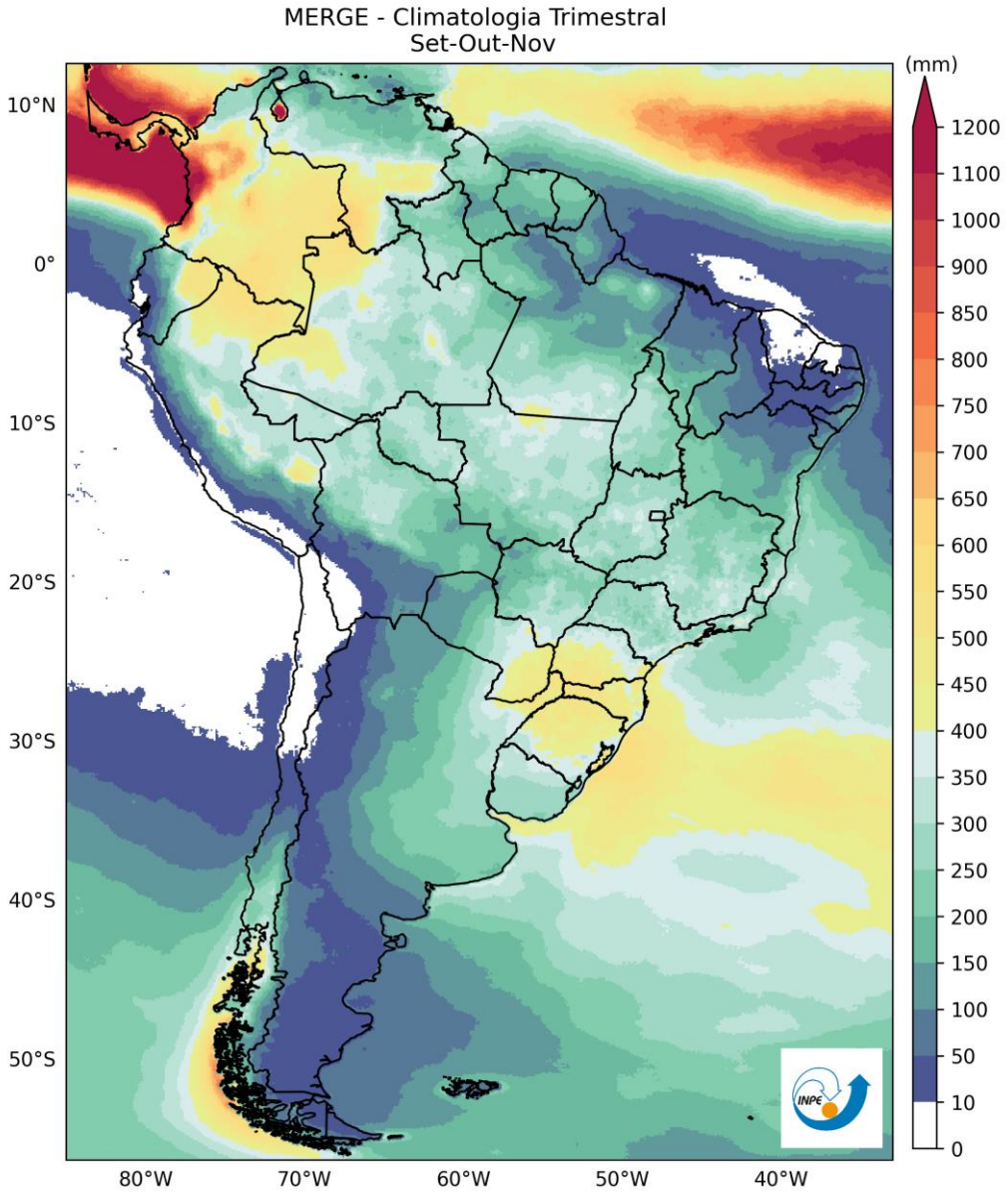

Fonte: Centro de Previsão de Tempo e Estudos Climáticos - CPTEC.

O conteúdo desta publicação foi produzido pelo ONS com base em dados e informações de conhecimento público. É de responsabilidade exclusiva dos agentes e demais interessados a obtenção de outros dados e informações, a realização de análises, estudos e avaliações para fins de tomada de decisões, definição de estratégias de atuação, assunção de compromissos e obrigações e quaisquer outras finalidades, em qualquer tempo e sob qualquer condição. É proibida a reprodução ou utilização total ou parcial do presente sem a identificação da fonte.

3.1.3. Previsão para a próxima semana

A passagem de uma frente fria pela Região Sul durante a semana ocasiona precipitação nas bacias dos rios Jacuí e Uruguai, com totais entre a média e abaixo da média semanal (Figura 4). Nas demais bacias hidrográficas de interesse do SIN não há previsão de precipitação significativa.

Figura 4 - Precipitação acumulada prevista pelo modelo ECMWF - período de 30/08 a 05/09/2025

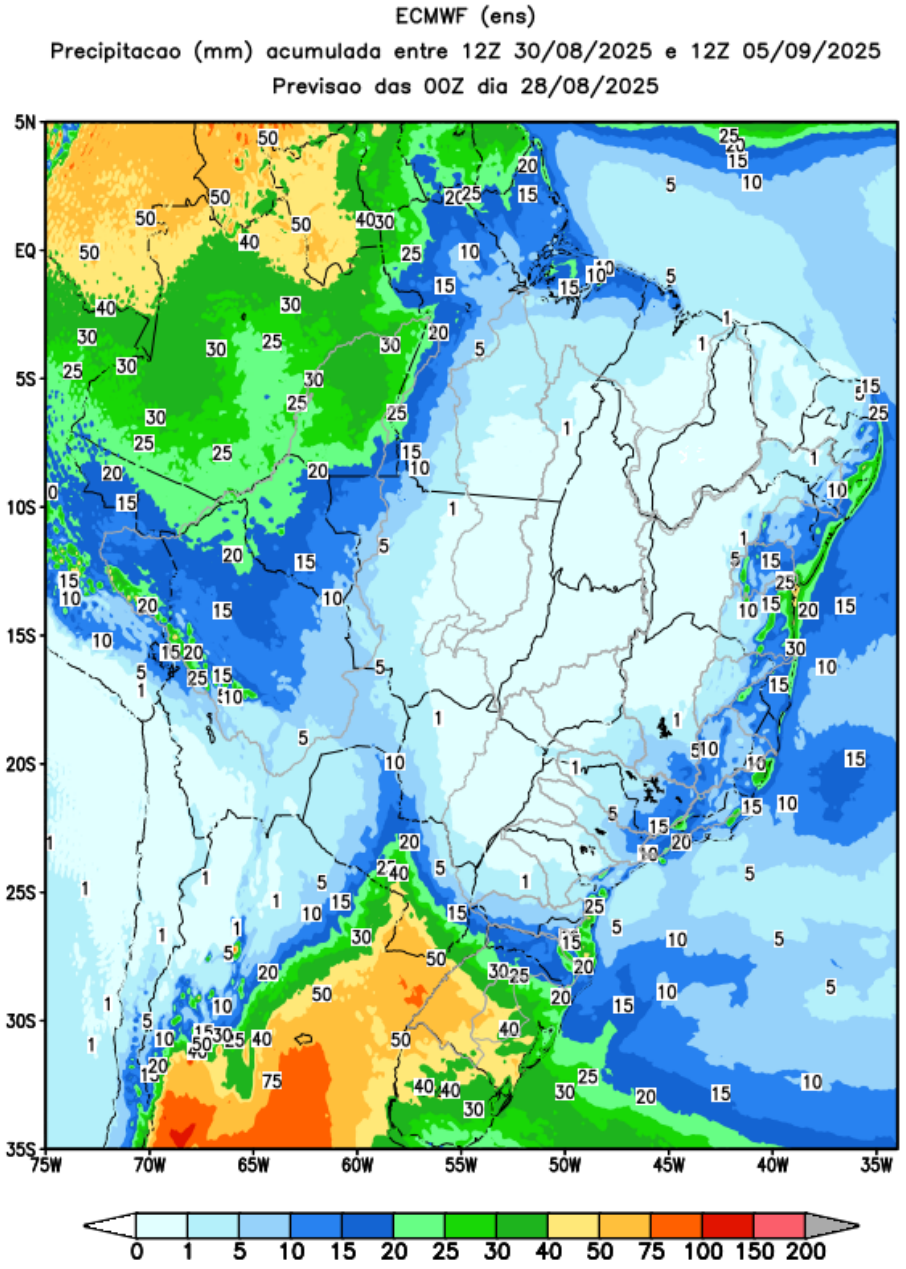

Em comparação com os valores estimados para a semana em curso, prevê-se para a próxima semana operativa ascensão nas afluências do subsistema Nordeste e recessão nas afluências dos subsistemas Sudeste/Centro-Oeste, Sul e Norte. A previsão mensal para setembro indica a ocorrência de afluências abaixo da média histórica para os subsistemas Sudeste/Centro-Oeste, Nordeste e Norte e acima da média histórica para o subsistema Sul.

O conteúdo desta publicação foi produzido pelo ONS com base em dados e informações de conhecimento público. É de responsabilidade exclusiva dos agentes e demais interessados a obtenção de outros dados e informações, a realização de análises, estudos e avaliações para fins de tomada de decisões, definição de estratégias de atuação, assunção de compromissos e obrigações e quaisquer outras finalidades, em qualquer tempo e sob qualquer condição. É proibida a reprodução ou utilização total ou parcial do presente sem a identificação da fonte.

Tabela 2 – Previsão de ENAs do PMO de Setembro/2025

PMO de Setembro/2025 - ENAs previstas				
Subsistema	30/08 a 05/09/2025		Mês de setembro	
	MWmed	%MLT	MWmed	%MLT
SE/CO	12.320	62	12.022	61
S	10.864	97	12.692	109
NE	1.378	46	1.366	47
N	1.609	64	1.372	61

As figuras a seguir ilustram as ENAs semanais previstas no PMO de Setembro/2025.

Figura 5 - Energias Naturais Afluentes ao Subsistema Sudeste/Centro-Oeste do PMO de Setembro/2025

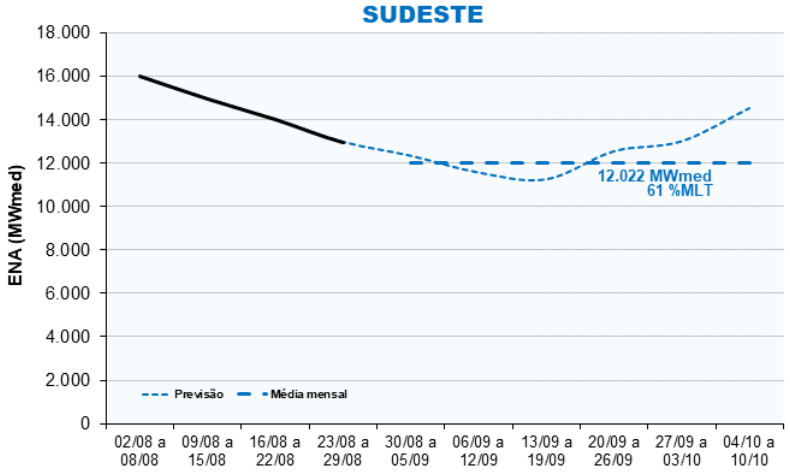

Figura 6 - Energias Naturais Afluentes ao Subsistema Sul do PMO de Setembro/2025

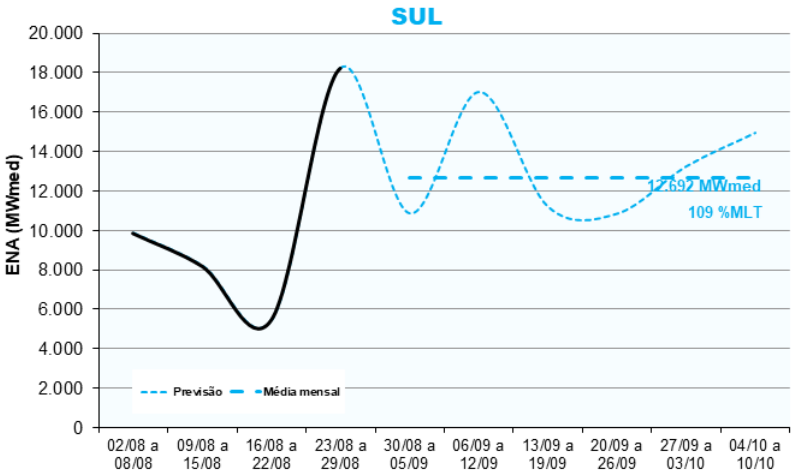

O conteúdo desta publicação foi produzido pelo ONS com base em dados e informações de conhecimento público. É de responsabilidade exclusiva dos agentes e demais interessados a obtenção de outros dados e informações, a realização de análises, estudos e avaliações para fins de tomada de decisões, definição de estratégias de atuação, assunção de compromissos e obrigações e quaisquer outras finalidades, em qualquer tempo e sob qualquer condição. É proibida a reprodução ou utilização total ou parcial do presente sem a identificação da fonte.

Figura 7 - Energias Naturais Afluentes ao Subsistema Nordeste do PMO de Setembro/2025

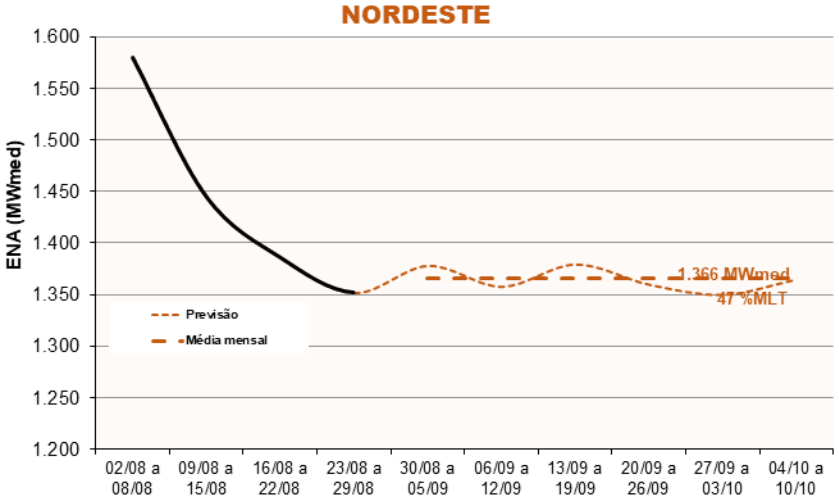

Figura 8 - Energias Naturais Afluentes ao Subsistema Norte do PMO de Setembro/2025

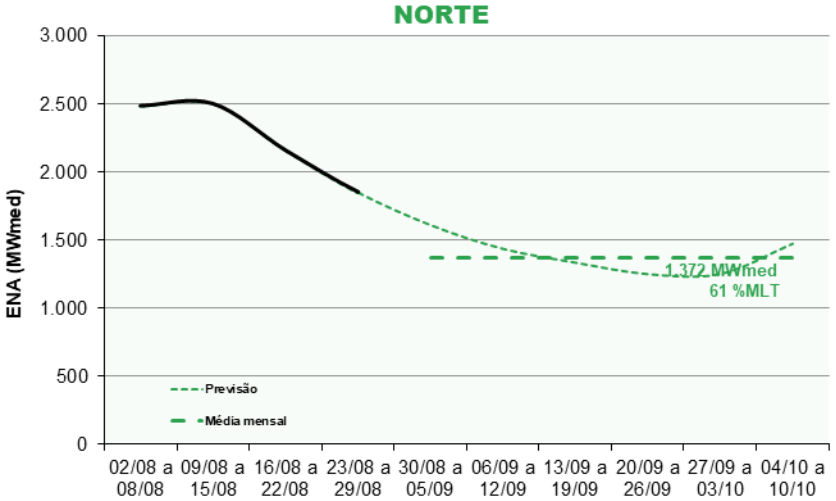

O conteúdo desta publicação foi produzido pelo ONS com base em dados e informações de conhecimento público. É de responsabilidade exclusiva dos agentes e demais interessados a obtenção de outros dados e informações, a realização de análises, estudos e avaliações para fins de tomada de decisões, definição de estratégias de atuação, assunção de compromissos e obrigações e quaisquer outras finalidades, em qualquer tempo e sob qualquer condição. É proibida a reprodução ou utilização total ou parcial do presente sem a identificação da fonte.

3.1.4. Cenários de ENAs para o PMO de Setembro/2025

As figuras a seguir apresentam as características dos cenários de energias naturais afluentes gerados no PMO de Setembro/2025, para acoplamento com a FCF do mês de outubro/2025. São mostradas, para os quatro subsistemas, as amplitudes e as Funções de Distribuição Acumulada dos cenários de ENA.

Figura 9 - Amplitude dos Cenários de ENA para o Subsistema Sudeste/Centro-Oeste, em %MLT, para o PMO de Setembro/2025

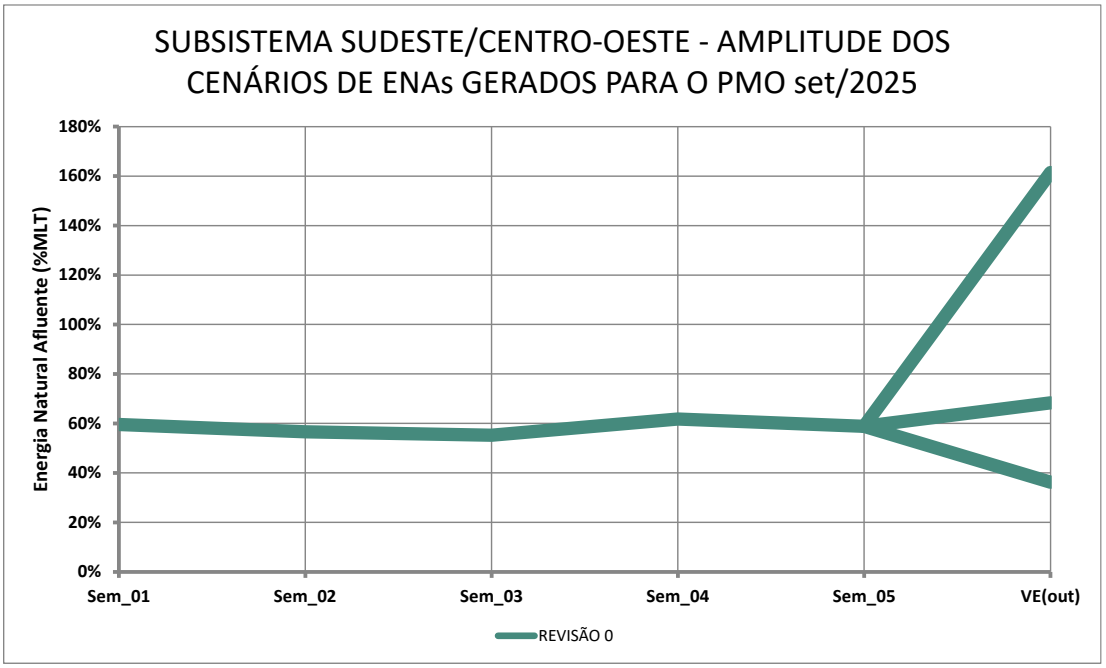

Figura 10 - Função de Distribuição Acumulada dos Cenários para o Subsistema Sudeste/Centro-Oeste para o PMO de Setembro/2025

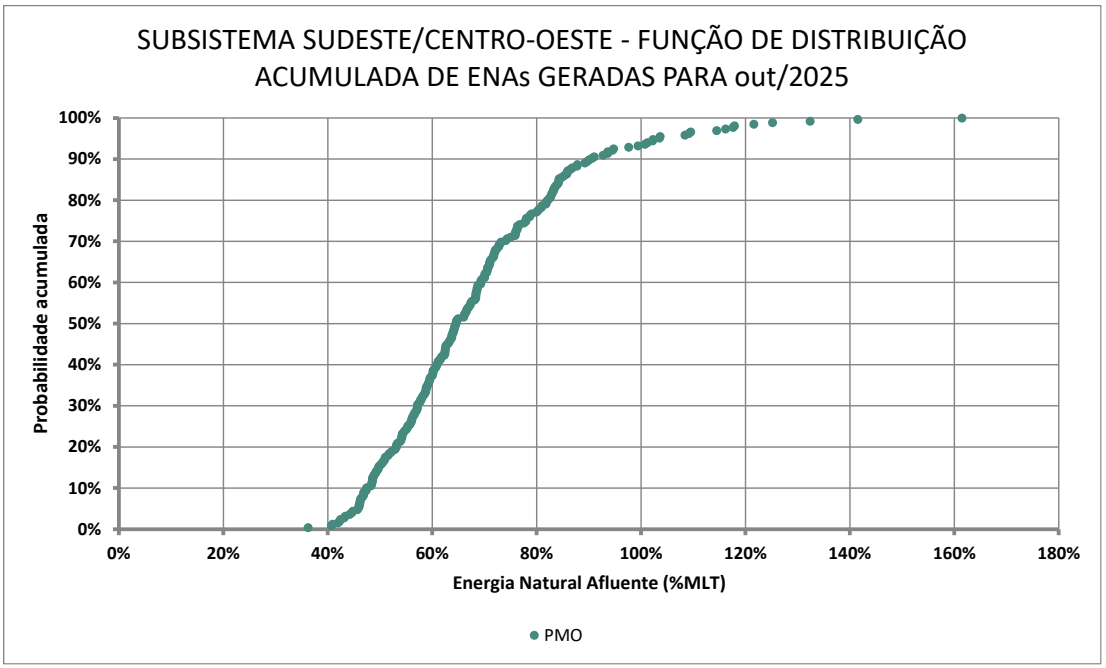

O conteúdo desta publicação foi produzido pelo ONS com base em dados e informações de conhecimento público. É de responsabilidade exclusiva dos agentes e demais interessados a obtenção de outros dados e informações, a realização de análises, estudos e avaliações para fins de tomada de decisões, definição de estratégias de atuação, assunção de compromissos e obrigações e quaisquer outras finalidades, em qualquer tempo e sob qualquer condição. É proibida a reprodução ou utilização total ou parcial do presente sem a identificação da fonte.

Figura 11 - Amplitude dos Cenários de ENA para o Subsistema Sul, em %MLT, para o PMO de Setembro/2025

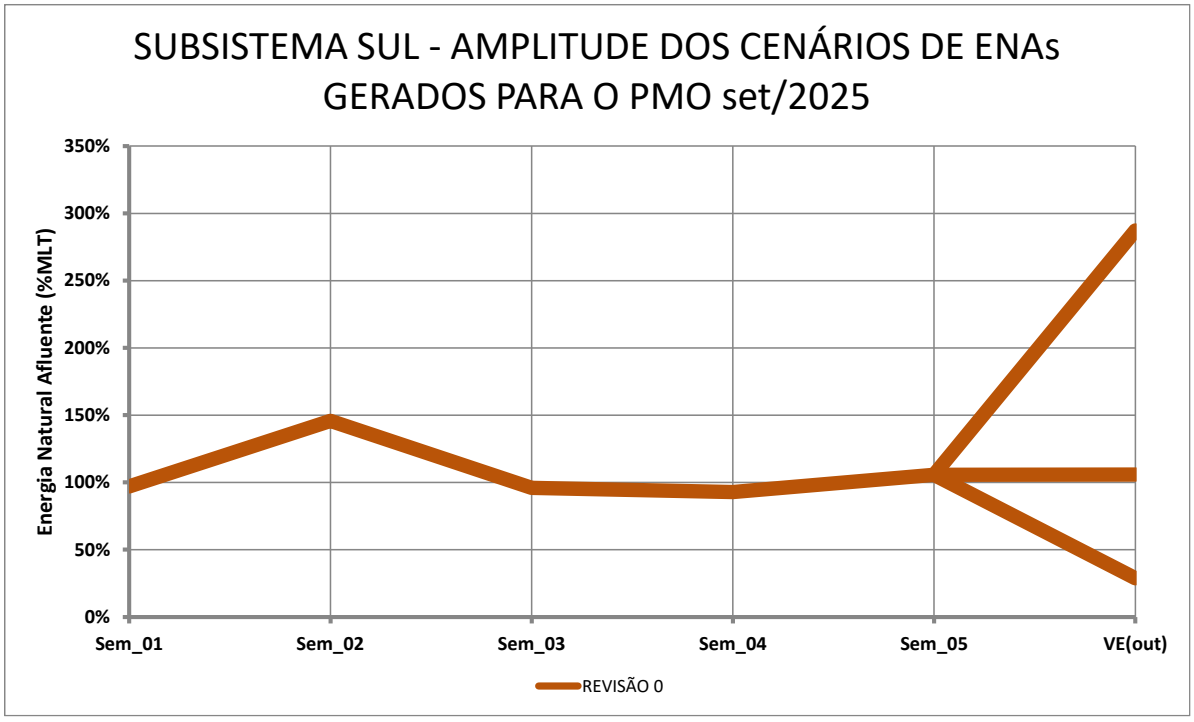

Figura 12 - Função de Distribuição Acumulada dos Cenários para o Subsistema Sul para o PMO de Setembro/2025

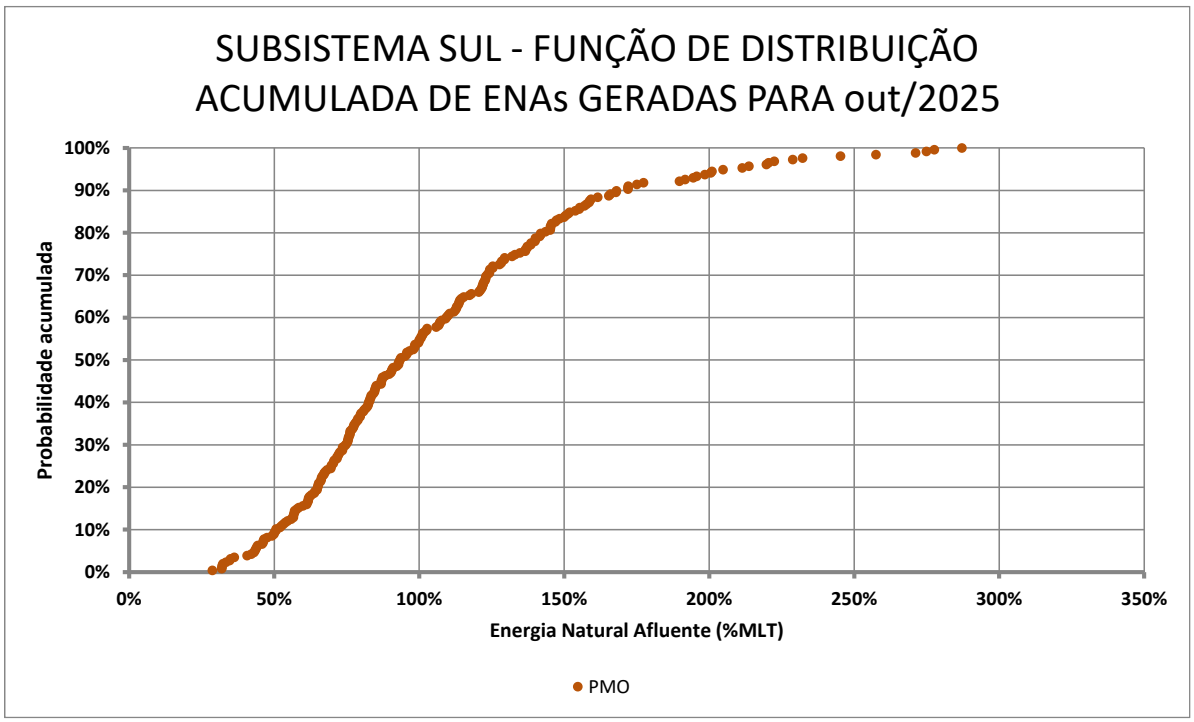

O conteúdo desta publicação foi produzido pelo ONS com base em dados e informações de conhecimento público. É de responsabilidade exclusiva dos agentes e demais interessados a obtenção de outros dados e informações, a realização de análises, estudos e avaliações para fins de tomada de decisões, definição de estratégias de atuação, assunção de compromissos e obrigações e quaisquer outras finalidades, em qualquer tempo e sob qualquer condição. É proibida a reprodução ou utilização total ou parcial do presente sem a identificação da fonte.

Figura 13 - Amplitude dos Cenários de ENA para o Subsistema Nordeste em %MLT, para o PMO de Setembro/2025

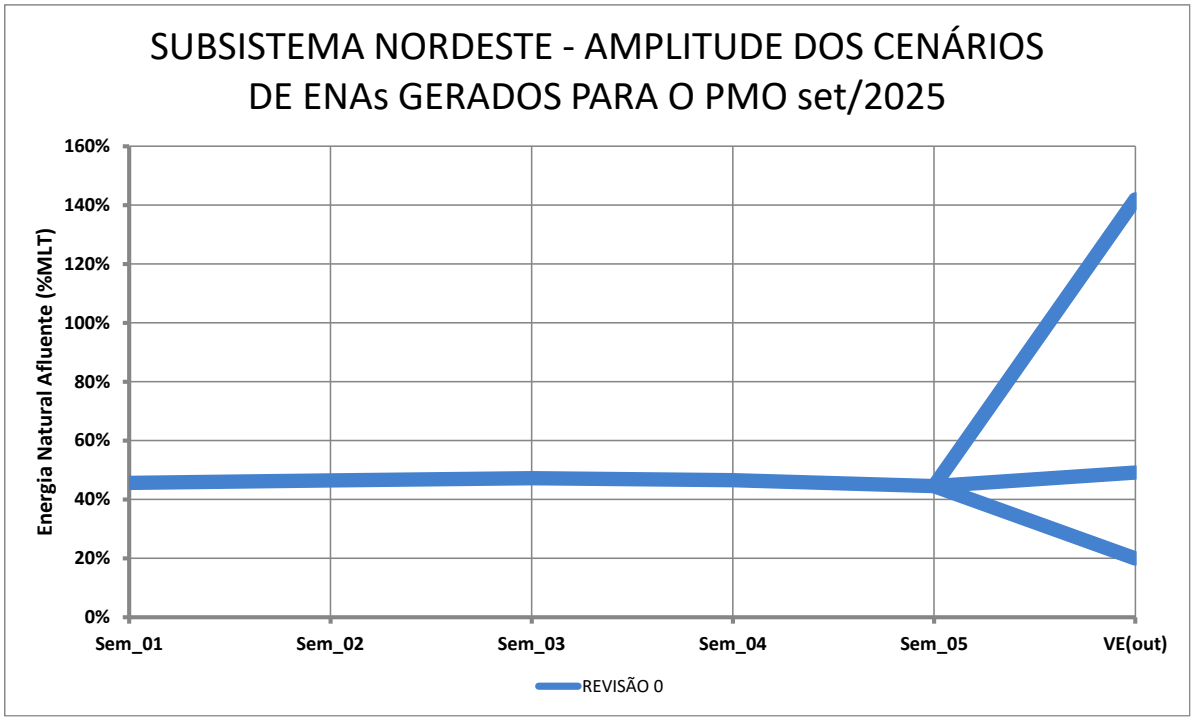

Figura 14 - Função de Distribuição Acumulada dos Cenários para o Subsistema Nordeste para o PMO de Setembro/2025

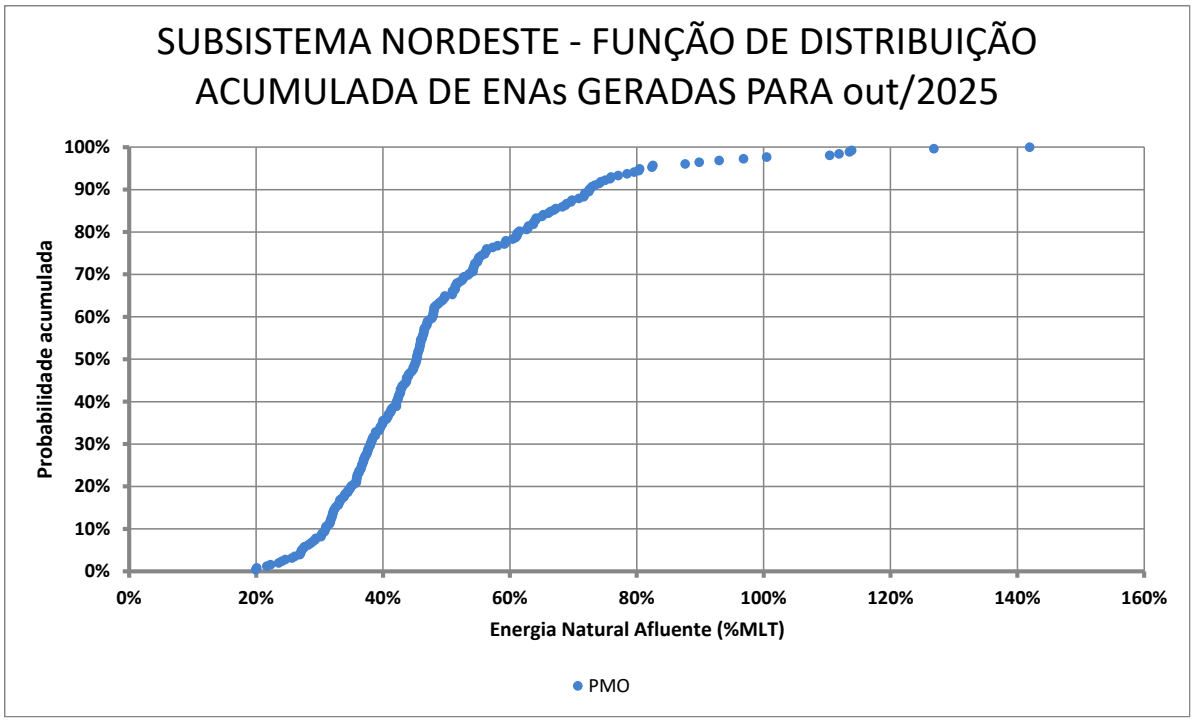

O conteúdo desta publicação foi produzido pelo ONS com base em dados e informações de conhecimento público. É de responsabilidade exclusiva dos agentes e demais interessados a obtenção de outros dados e informações, a realização de análises, estudos e avaliações para fins de tomada de decisões, definição de estratégias de atuação, assunção de compromissos e obrigações e quaisquer outras finalidades, em qualquer tempo e sob qualquer condição. É proibida a reprodução ou utilização total ou parcial do presente sem a identificação da fonte.

Figura 15 - Amplitude dos Cenários de ENA para o Subsistema Norte, em %MLT, para o PMO de Setembro/2025

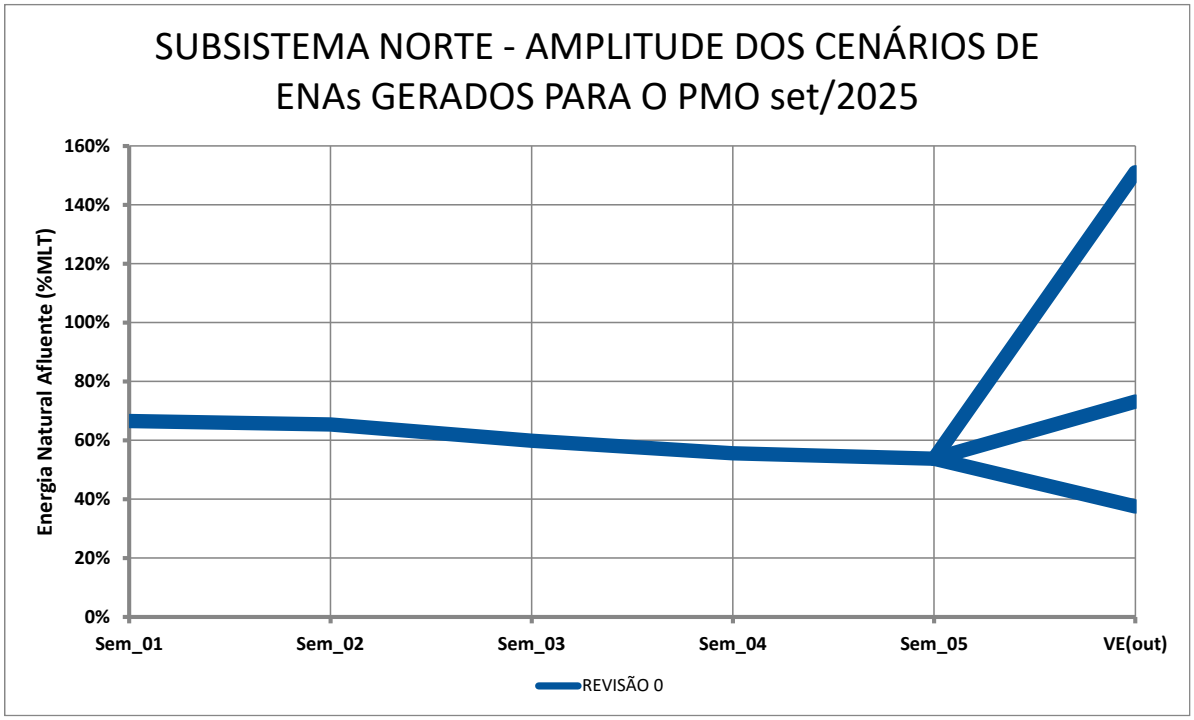

Figura 16 - Função de Distribuição Acumulada dos Cenários para o Subsistema Norte para o PMO de Setembro/2025

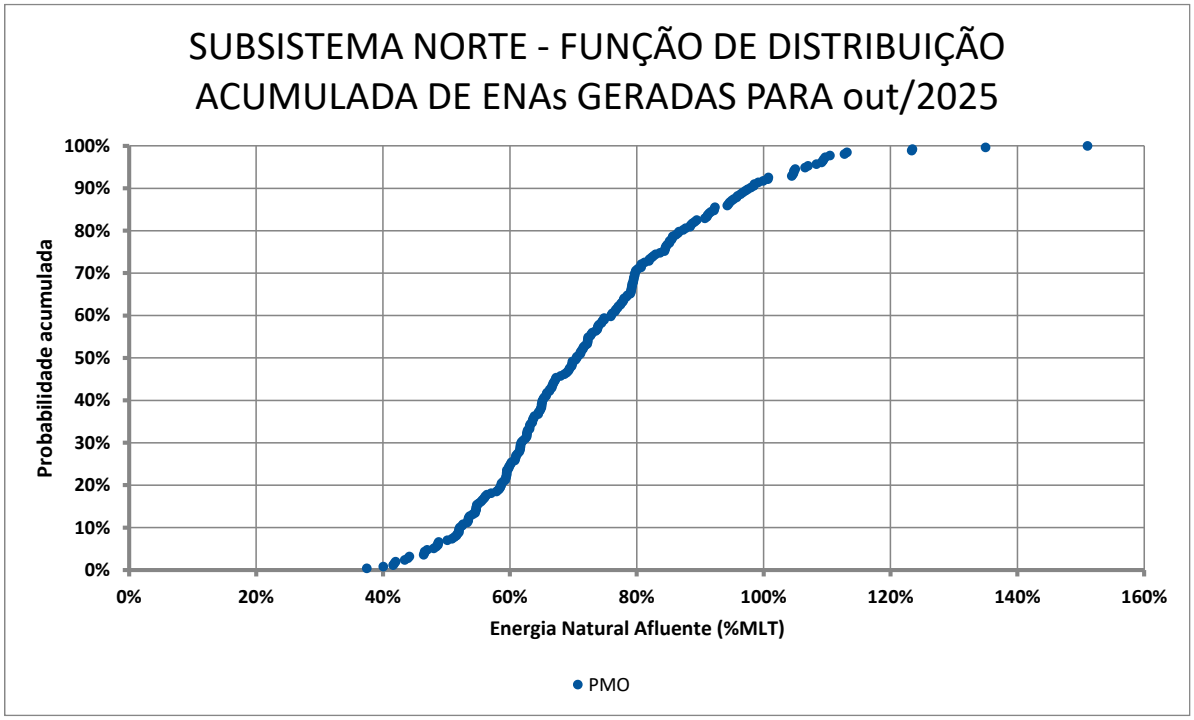

O conteúdo desta publicação foi produzido pelo ONS com base em dados e informações de conhecimento público. É de responsabilidade exclusiva dos agentes e demais interessados a obtenção de outros dados e informações, a realização de análises, estudos e avaliações para fins de tomada de decisões, definição de estratégias de atuação, assunção de compromissos e obrigações e quaisquer outras finalidades, em qualquer tempo e sob qualquer condição. É proibida a reprodução ou utilização total ou parcial do presente sem a identificação da fonte.

Os valores da MLT (Média de Longo Termo) das energias naturais afluentes para os meses de setembro/2025 e outubro/2025 são apresentados na tabela a seguir.

Tabela 3 – MLT da ENA nos meses de setembro/2025 e outubro/2025

MLT das ENAs (MWmed)		
Subsistema	setembro	outubro
SE/CO	19.629	23.676
S	11.676	13.704
NE	2.923	3.172
N	2.260	2.372

3.2. Limites de Intercâmbio entre Subsistemas

Os limites elétricos de intercâmbio de energia entre subsistemas são de fundamental importância para o processo de otimização energética, sendo determinantes para a definição das políticas de operação e do CMO para cada subsistema. Estes limites são influenciados por intervenções na malha de transmissão, notadamente na primeira semana operativa. O diagrama a seguir ilustra os fluxos notáveis do SIN e os limites aplicados neste PMO.

Figura 17 – Interligações entre regiões

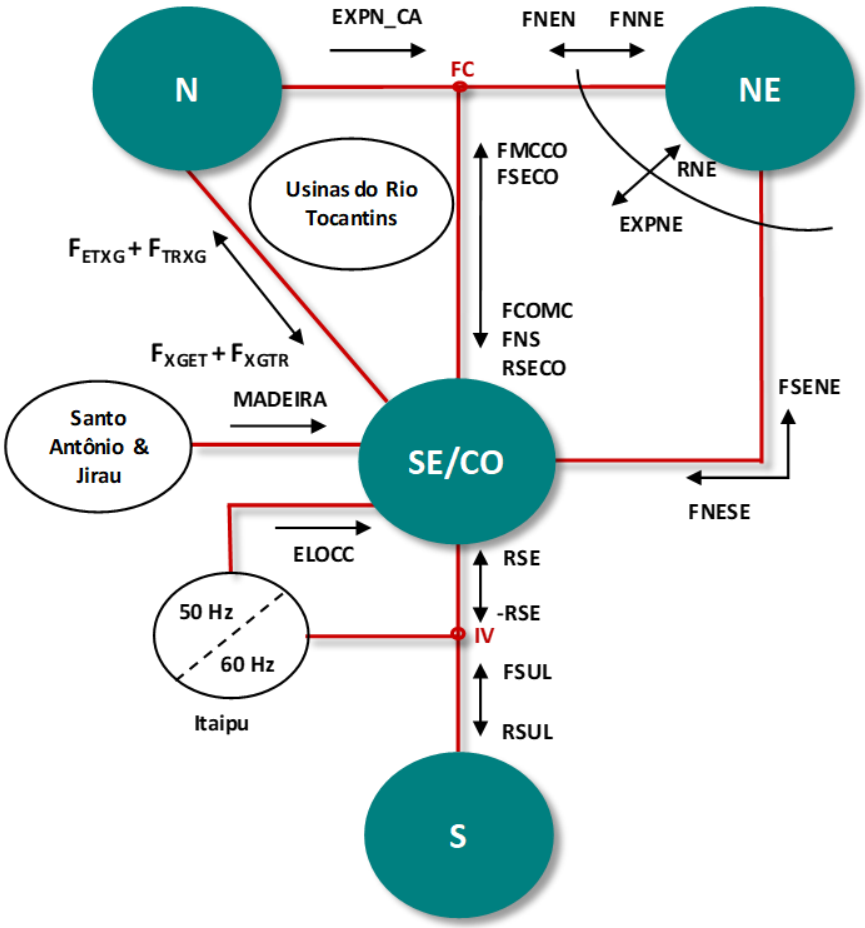

O conteúdo desta publicação foi produzido pelo ONS com base em dados e informações de conhecimento público. É de responsabilidade exclusiva dos agentes e demais interessados a obtenção de outros dados e informações, a realização de análises, estudos e avaliações para fins de tomada de decisões, definição de estratégias de atuação, assunção de compromissos e obrigações e quaisquer outras finalidades, em qualquer tempo e sob qualquer condição. É proibida a reprodução ou utilização total ou parcial do presente sem a identificação da fonte.

Tabela 4 – Limites considerados nesta semana operativa para intercâmbio de energia

Limites de Intercâmbio (MWmed)				
Fluxo	Patamar	30/08 a 05/09/2025		Demais Semanas
RNE	Pesada	11.000		11.000
	Média	11.000		11.000
	Leve	11.000		11.000
FNS	Pesada	**5.000**	(A) (B) (C)	5.200
	Média	**4.817**		5.200
	Leve	**4.337**		5.000
FNNE	Pesada	**7.640**	(D) (E)	7.800
	Média	**6.987**		7.800
	Leve	**6.134**		7.800
EXPORT. NE	Pesada	13.800		13.800
	Média	13.800		13.800
	Leve	13.800		13.800
FMCCO	Pesada	5.000		5.000
	Média	5.000		5.000
	Leve	5.000		5.000
FSENE	Pesada	6.000		6.000
	Média	6.000		6.000
	Leve	6.000		6.000
FNS + FNESE	Pesada	**11.000**	(B) (C)	11.200
	Média	**10.030**		10.267
	Leve	**10.904**		11.200
RSE	Pesada	**8.200**	(F) (G)	10.200
	Média	**8.408**		10.200
	Leve	**9.517**		10.880
FORNEC. SUL	Pesada	7.000		7.000
	Média	7.000		7.000
	Leve	8.600		8.600

Limites de Intercâmbio (MWmed)				
Fluxo	Patamar	30/08 a 05/09/2025		Demais Semanas
RECEB. SUL	Pesada	**6.637**	(F) (G) (H) (I) (J) (K)	7.300
	Média	**5.683**		6.050
	Leve	**6.563**		7.300
ELO CC 50 Hz	Pesada	**2.171**	(H) (I) (J) (K)	3.000
	Média	**2.050**		3.000
	Leve	**2.096**		3.000
ITAIPU 60 Hz	Pesada	**6.600**	(L)	7.200
	Média	**6.710**		7.200
	Leve	**6.962**		7.200
EXP. N CA	Pesada	8.000		8.000
	Média	8.000		8.000
	Leve	8.000		8.000
FETXG + FTRXG	Pesada	4.200		4.200
	Média	1.000		1.000
	Leve	1.000		1.000
FXGET + FXGTR	Pesada	3.000		3.000
	Média	3.000		3.000
	Leve	3.000		3.000
FNESE	Pesada	8.500	(D) (M)	8.500
	Média	**8.279**		8.335
	Leve	**7.727**		8.500
FNEN	Pesada	**6.131**	(D) (E)	6.200
	Média	**5.913**		6.200
	Leve	**5.679**		6.200
Ger_MADEIRA	Pesada	2.609		2.609
	Média	2.609		2.609
	Leve	2.609		2.609

(A) SGI 64-25
(B) SGI 44.467-25
(C) SGI 45.720-25
(D) SGI 41.083-25
(E) SGI 51.636-25
(F) SGI 42.900-25
(G) SGI 50.092-25
(H) SGI 47.711-25
(I) SGI 48.047-25
(J) SGI 48.039-25
(K) SGI 49.552-25
(L) SGI 47.724-25
(M) SGI 49.897-25

O conteúdo desta publicação foi produzido pelo ONS com base em dados e informações de conhecimento público. É de responsabilidade exclusiva dos agentes e demais interessados a obtenção de outros dados e informações, a realização de análises, estudos e avaliações para fins de tomada de decisões, definição de estratégias de atuação, assunção de compromissos e obrigações e quaisquer outras finalidades, em qualquer tempo e sob qualquer condição. É proibida a reprodução ou utilização total ou parcial do presente sem a identificação da fonte.

3.3. Previsão de carga

Em agosto de 2025, a confiança da indústria registrou a maior retração desde a pandemia, com o Índice de Confiança da Indústria (ICI) recuando para o menor nível desde outubro de 2023. A queda, sexta consecutiva no ano, reflete a piora tanto nas avaliações sobre a situação atual quanto nas expectativas para os próximos meses. Segundo a FGV, a combinação entre política monetária restritiva, aumento da incerteza externa e novas taxações sobre produtos brasileiros tem ampliado os desafios do setor. Apesar de o Nível de Utilização da Capacidade Instalada (NUCI) ter se mantido estável, o avanço dos estoques sinaliza demanda mais fraca. Esse cenário reforça os sinais de desaceleração da atividade industrial e tende a impactar setores energointensivos, como metalurgia, papel e celulose, e produtos químicos, com efeitos relevantes sobre a carga do Sistema Interligado Nacional (SIN).

Com base no fechamento do PMO de Setembro, as projeções de carga indicam variações de -3,3% no Subsistema Sudeste/Centro-Oeste, 4,7% no Sul, 0,9% no Nordeste e 0,3% no Norte, na comparação com o mesmo mês de 2024.

A estimativa para a semana operativa atual (23/08 a 29/08) aponta alta de 1,2% no SIN frente à semana anterior, totalizando 77.844 MW médios. O avanço é explicado, sobretudo, pelos crescimentos nos Subsistemas Sudeste/Centro-Oeste (1,7%) e Nordeste (2,4%). No Norte, a alta foi discreta (0,7%), enquanto o Sul apresentou retração de 1,2% devido à queda nas temperaturas em Porto Alegre e Florianópolis.

No consolidado de agosto, temperaturas máximas abaixo da média histórica no Sudeste, Centro-Oeste e Sul influenciaram o desempenho da carga, com destaque para o Sul, que ficou abaixo das previsões. Nos demais subsistemas, os desvios foram menores, com desvio máximo de 2,2%.

Para setembro, a expectativa é de crescimento de 5,5% na carga do SIN, impulsionado por temperaturas acima da média histórica na maior parte do país. Apenas o Sul deve registrar temperaturas próximas à média. O Sudeste/Centro-Oeste e Sul devem apresentar as maiores variações projetadas de carga, já que são regiões mais sensíveis à variabilidade climática.

Tabela 5 – Evolução da carga do PMO de Setembro de 2025

Subsistema	CARGA SEMANAL (MWmed)					CARGA MENSAL (MWmed)	
	1ª Sem	2ª Sem	3ª Sem	4ª Sem	5ª Sem	set/25	Var. (%) set/25 -> set/24
SE/CO	44.779	44.840	45.313	45.413	45.642	45.181	-3,3%
Sul	13.472	13.492	13.539	13.772	13.711	13.594	4,7%
Nordeste	12.888	12.945	13.198	13.501	13.709	13.226	0,9%
Norte	8.449	8.450	8.499	8.460	8.490	8.469	0,3%
SIN	**79.589**	**79.727**	**80.549**	**81.146**	**81.552**	**80.470**	**-1,0%**

O conteúdo desta publicação foi produzido pelo ONS com base em dados e informações de conhecimento público. É de responsabilidade exclusiva dos agentes e demais interessados a obtenção de outros dados e informações, a realização de análises, estudos e avaliações para fins de tomada de decisões, definição de estratégias de atuação, assunção de compromissos e obrigações e quaisquer outras finalidades, em qualquer tempo e sob qualquer condição. É proibida a reprodução ou utilização total ou parcial do presente sem a identificação da fonte.

3.4. Potência Hidráulica Total Disponível no SIN

O gráfico a seguir mostra a disponibilidade hidráulica total do SIN, para este mês, de acordo com o cronograma de manutenção informado pelos agentes para este PMO.

Figura 18 – Potência hidráulica disponível no SIN

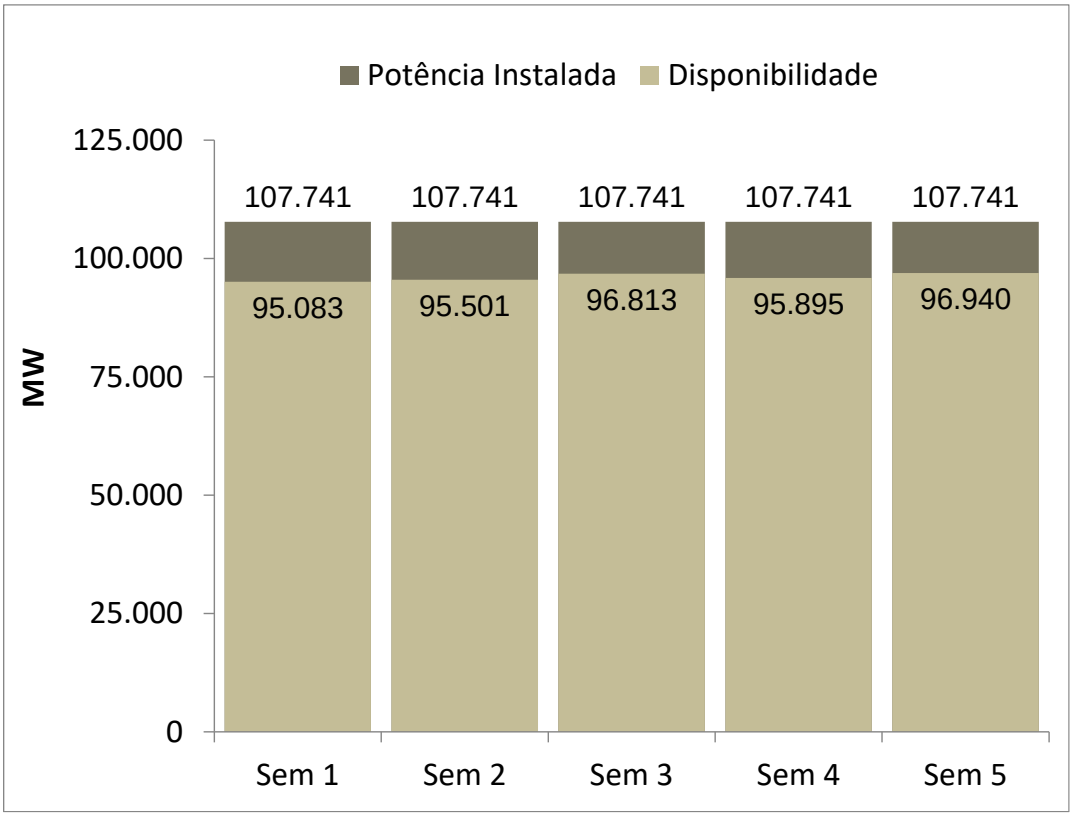

3.5. Armazenamentos Iniciais por Subsistema

Tabela 6 – Armazenamentos iniciais, por subsistema, considerados para esta semana operativa

Armazenamento (%EARmáx) - 0:00 h do dia 30/08/2025		
Subsistema	**Nível previsto na Revisão 4 do PMO Ago/2025**	**Partida informada pelos Agentes para a Revisão 0 do PMO Set/2025**
SE/CO	58,4	58,1
S	79,9	87,3
NE	60,0	60,1
N	87,0	87,4

A primeira coluna da tabela acima corresponde ao armazenamento previsto na Revisão 4 do PMO de Agosto de 2025, para a 0:00 h do dia 30/08/2025. A segunda coluna apresenta os armazenamentos obtidos a partir dos níveis de partida informados pelos Agentes de Geração para seus aproveitamentos com reservatórios.

O conteúdo desta publicação foi produzido pelo ONS com base em dados e informações de conhecimento público. É de responsabilidade exclusiva dos agentes e demais interessados a obtenção de outros dados e informações, a realização de análises, estudos e avaliações para fins de tomada de decisões, definição de estratégias de atuação, assunção de compromissos e obrigações e quaisquer outras finalidades, em qualquer tempo e sob qualquer condição. É proibida a reprodução ou utilização total ou parcial do presente sem a identificação da fonte.

4. PRINCIPAIS RESULTADOS

4.1. Política de Operação Energética

Para esta semana operativa, está prevista a seguinte política de intercâmbio de energia entre regiões:

Região SE/CO:

- Geração dimensionada para controle de nível e atendimento nos períodos de carga média e pesada;

- Alocação da Folga de Potência Monitorada nas usinas de cabeceira dos rios Grande e Paranaíba.

Região Sul:

- Geração dimensionada para controle de nível em função das condições hidrológicas;

- Atendimento em todos os períodos de carga do SIN.

Região NE:

- Geração hidráulica em atendimento à Res. ANA 2.081/2017 minimizada para alocação de geração renováveis do NE.

Região Norte:

- Exploração dos recursos em função das disponibilidades energéticas e atendimento nos períodos de carga pesada;

- Alocação da Folga de Potência Monitorada na UHE Tucuruí.

4.2. Custo Marginal de Operação – CMO

A figura a seguir apresenta os Custos Marginais de Operação, em valores médios semanais, para as semanas operativas deste mês.

Figura 19 – CMO em valores médios

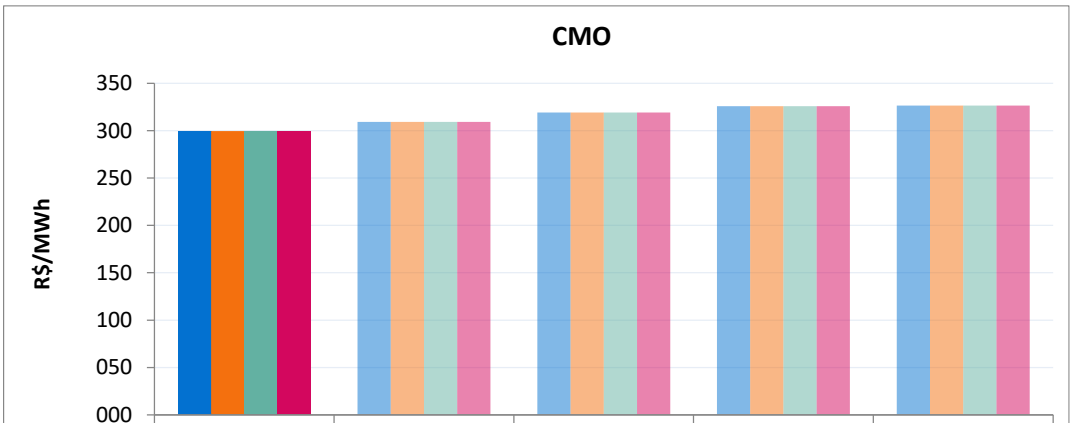

	Sem1	Sem2	Sem3	Sem4	Sem5
Sudeste	299,76	309,29	319,17	326,04	326,52
Sul	299,76	309,29	319,17	326,04	326,52
Nordeste	299,76	309,29	319,17	326,04	326,52
Norte	299,76	309,29	319,17	326,04	326,52

O conteúdo desta publicação foi produzido pelo ONS com base em dados e informações de conhecimento público. É de responsabilidade exclusiva dos agentes e demais interessados a obtenção de outros dados e informações, a realização de análises, estudos e avaliações para fins de tomada de decisões, definição de estratégias de atuação, assunção de compromissos e obrigações e quaisquer outras finalidades, em qualquer tempo e sob qualquer condição. É proibida a reprodução ou utilização total ou parcial do presente sem a identificação da fonte.

A tabela a seguir apresenta o custo marginal de operação, por subsistema e patamar de carga, para a próxima semana operativa.

Tabela 7 – CMO para esta semana operativa

Patamares de Carga	CMO (R$/MWh)			
	SE/CO	S	NE	N
Pesada	317,27	317,27	317,27	317,27
Média	304,96	304,96	304,96	304,96
Leve	287,09	287,09	287,09	287,09
Média Semanal	299,76	299,76	299,76	299,76

4.3. Energia Armazenada

O processo de otimização realizado pelo programa DECOMP indicou os armazenamentos mostrados na figura a seguir para as próximas semanas operativas do mês de setembro/2025.

Figura 20 – Energias Armazenadas nas semanas operativas do mês de setembro/2025

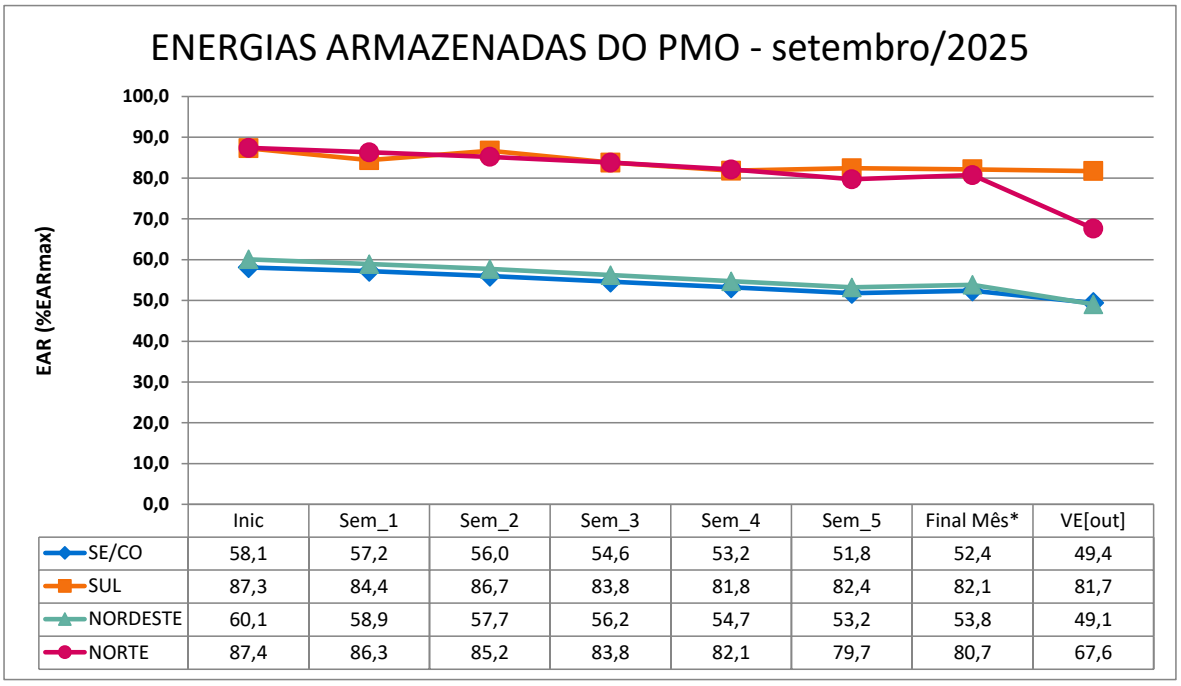

	Inic	Sem_1	Sem_2	Sem_3	Sem_4	Sem_5	Final Mês*	VE[out]
SE/CO	58,1	57,2	56,0	54,6	53,2	51,8	52,4	49,4
SUL	87,3	84,4	86,7	83,8	81,8	82,4	82,1	81,7
NORDESTE	60,1	58,9	57,7	56,2	54,7	53,2	53,8	49,1
NORTE	87,4	86,3	85,2	83,8	82,1	79,7	80,7	67,6

Os armazenamentos da figura anterior estão expressos em percentual da Energia Armazenável Máxima de cada subsistema, que são mostradas na tabela a seguir.

Tabela 8 – Energia Armazenável Máxima por subsistema no PMO de Setembro/2025

ENERGIA ARMAZENÁVEL MÁXIMA (MWmed)		
Subsistema	setembro	outubro
SE/CO	205.390	205.390
S	20.458	20.458
NE	51.718	51.718
N	15.842	15.885

O conteúdo desta publicação foi produzido pelo ONS com base em dados e informações de conhecimento público. É de responsabilidade exclusiva dos agentes e demais interessados a obtenção de outros dados e informações, a realização de análises, estudos e avaliações para fins de tomada de decisões, definição de estratégias de atuação, assunção de compromissos e obrigações e quaisquer outras finalidades, em qualquer tempo e sob qualquer condição. É proibida a reprodução ou utilização total ou parcial do presente sem a identificação da fonte.

5. GERAÇÃO TÉRMICA

A Figura 21 apresenta, para cada subsistema do SIN, o despacho térmico por modalidade indicado pelo Decomp para esta semana operativa.

Figura 21 – Geração térmica para a próxima semana operativa

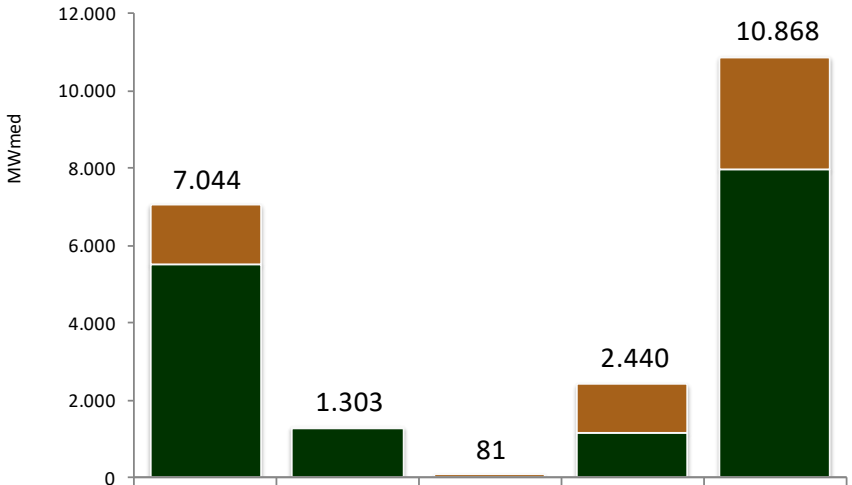

	SE/CO	SUL	NE	NORTE	SIN
TOTAL	7.044	1.303	81	2.440	10.868
ORDEM DE MÉRITO	1518	43	77	1271	2909
RESTRIÇÃO ELÉTRICA	0	0	0	0	0
INFLEXIBILIDADE	5526	1260	4	1169	7959

O gráfico a seguir apresenta a expectativa de despacho Térmico para os dois meses do horizonte de estudo.

Figura 22 – Expectativa de despacho térmico para o horizonte de dois meses

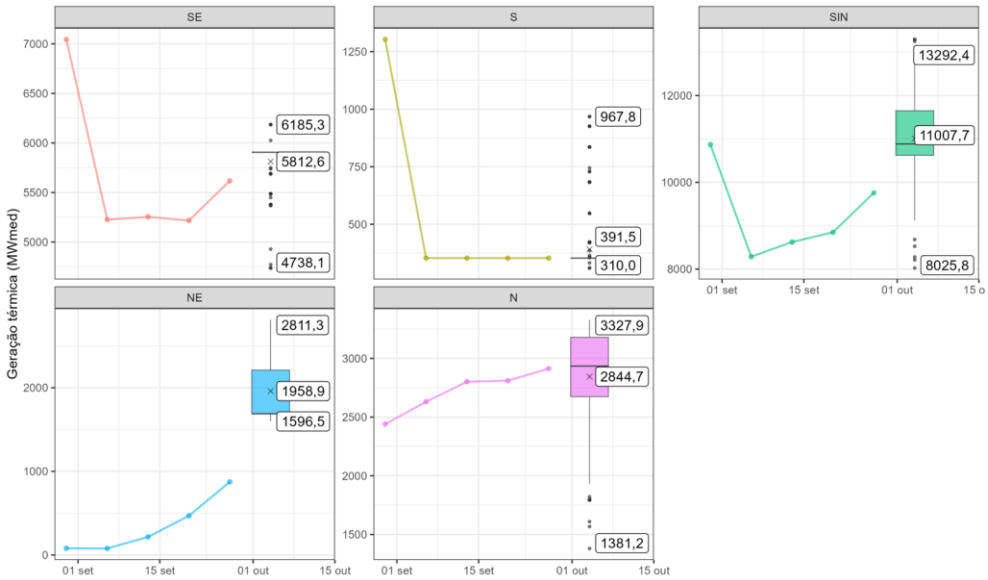

O conteúdo desta publicação foi produzido pelo ONS com base em dados e informações de conhecimento público. É de responsabilidade exclusiva dos agentes e demais interessados a obtenção de outros dados e informações, a realização de análises, estudos e avaliações para fins de tomada de decisões, definição de estratégias de atuação, assunção de compromissos e obrigações e quaisquer outras finalidades, em qualquer tempo e sob qualquer condição. É proibida a reprodução ou utilização total ou parcial do presente sem a identificação da fonte.

Na tabela abaixo segue a indicação de despacho antecipado por ordem de mérito de custo para a semana de 01/11/2025 a 07/11/2025.

Tabela 9 – UTEs com contrato de combustível GNL

UTE			Benefício (R$/MWh)			Despacho antecipado por mérito		
Nome	Código	CVU (R$/MWh)	Carga Pesada	Carga Média	Carga Leve	Carga Pesada	Carga Média	Carga Leve
SANTA CRUZ	86	217,45	325,42	319,12	313,67	Sim	Sim	Sim
LUIZORMELO	15	327,91	325,42	319,12	313,67	Não	Não	Não
PSERGIPE I	224	335,71	324,63	319,06	313,67	Não	Não	Não

Assim sendo, há previsão de despacho antecipado por ordem de mérito de custo para a UTE Santa Cruz para a semana de 01/11/2025 a 07/11/2025. Para as UTE Luiz O. R. Melo e Porto Sergipe I não há previsão de despacho antecipado por ordem de mérito para a referida semana.

O conteúdo desta publicação foi produzido pelo ONS com base em dados e informações de conhecimento público. É de responsabilidade exclusiva dos agentes e demais interessados a obtenção de outros dados e informações, a realização de análises, estudos e avaliações para fins de tomada de decisões, definição de estratégias de atuação, assunção de compromissos e obrigações e quaisquer outras finalidades, em qualquer tempo e sob qualquer condição. É proibida a reprodução ou utilização total ou parcial do presente sem a identificação da fonte.

6. RESUMO DOS RESULTADOS DO PMO

As figuras a seguir apresentam um resumo dos resultados do PMO de setembro/2025, com informações da Energia Natural Afluente (ENA), da Energia Armazenada (EAR) e do Custo Marginal de Operação (CMO) nos subsistemas do Sistema Interligado Nacional (SIN). São apresentados os valores semanais observados e previstos e o valor esperado dos cenários gerados para o mês de outubro/2025.

Figura 23 – Resumo de setembro/2025 para o Subsistema Sudeste/Centro-Oeste

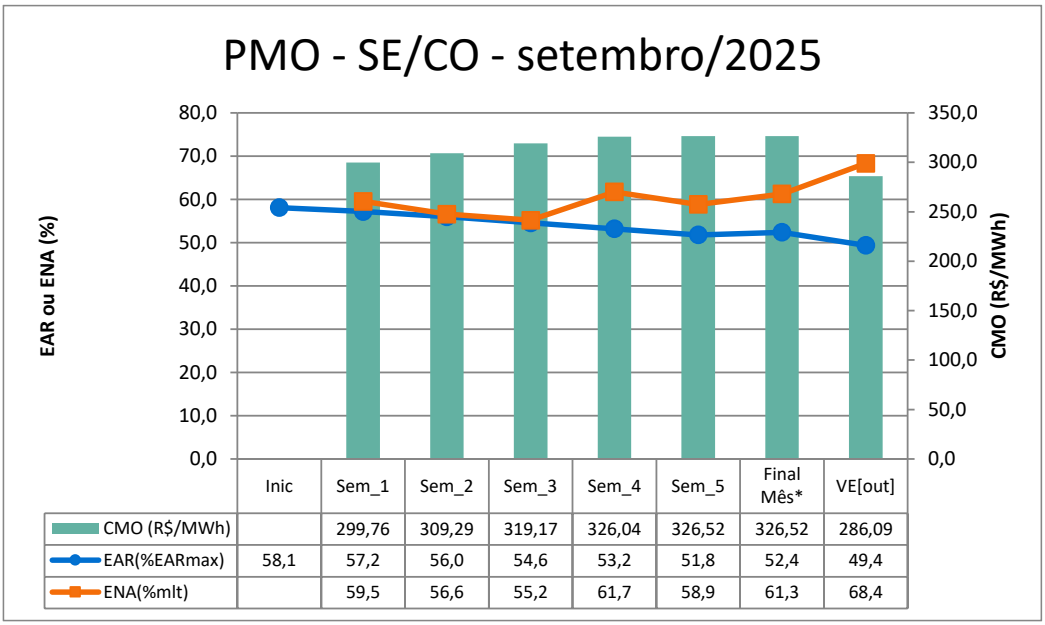

	Inic	Sem_1	Sem_2	Sem_3	Sem_4	Sem_5	Final Mês*	VE[out]
CMO (R$/MWh)		299,76	309,29	319,17	326,04	326,52	326,52	286,09
EAR(%EARmax)	58,1	57,2	56,0	54,6	53,2	51,8	52,4	49,4
ENA(%mlt)		59,5	56,6	55,2	61,7	58,9	61,3	68,4

Figura 24 – Resumo de setembro/2025 para o Subsistema Sul

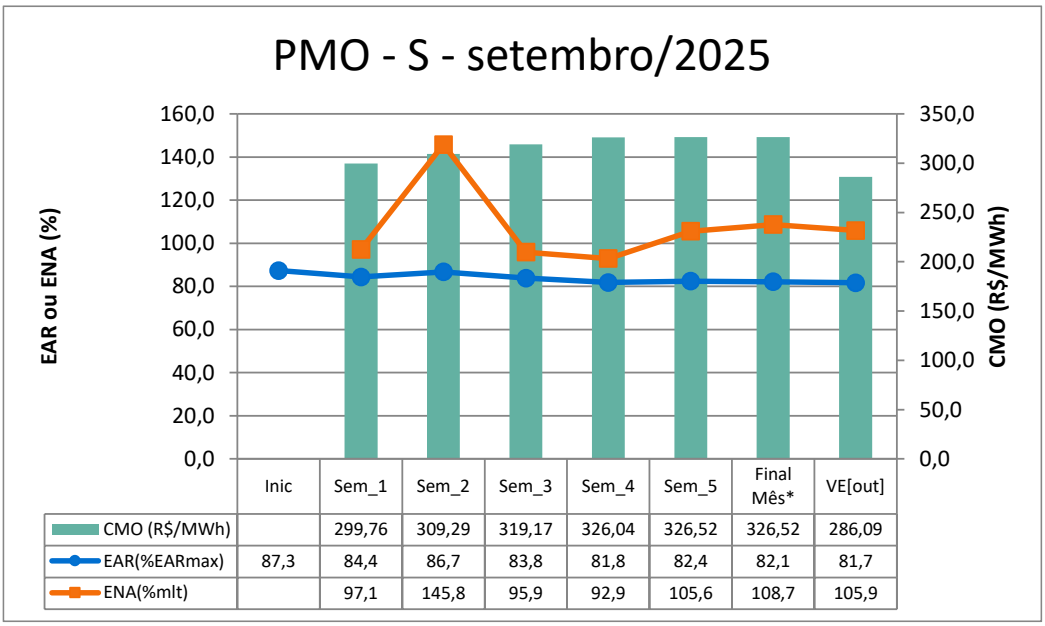

	Inic	Sem_1	Sem_2	Sem_3	Sem_4	Sem_5	Final Mês*	VE[out]
CMO (R$/MWh)		299,76	309,29	319,17	326,04	326,52	326,52	286,09
EAR(%EARmax)	87,3	84,4	86,7	83,8	81,8	82,4	82,1	81,7
ENA(%mlt)		97,1	145,8	95,9	92,9	105,6	108,7	105,9

O conteúdo desta publicação foi produzido pelo ONS com base em dados e informações de conhecimento público. É de responsabilidade exclusiva dos agentes e demais interessados a obtenção de outros dados e informações, a realização de análises, estudos e avaliações para fins de tomada de decisões, definição de estratégias de atuação, assunção de compromissos e obrigações e quaisquer outras finalidades, em qualquer tempo e sob qualquer condição. É proibida a reprodução ou utilização total ou parcial do presente sem a identificação da fonte.

Figura 25 – Resumo de setembro/2025 para o Subsistema Nordeste

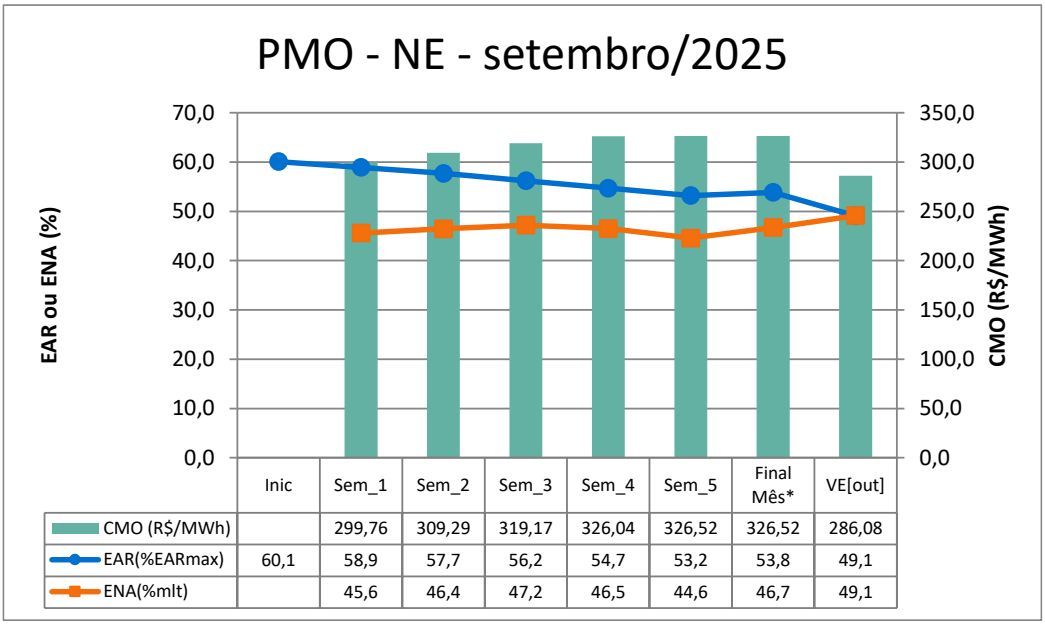

	Inic	Sem_1	Sem_2	Sem_3	Sem_4	Sem_5	Final Mês*	VE[out]
CMO (R$/MWh)		299,76	309,29	319,17	326,04	326,52	326,52	286,08
EAR(%EARmax)	60,1	58,9	57,7	56,2	54,7	53,2	53,8	49,1
ENA(%mlt)		45,6	46,4	47,2	46,5	44,6	46,7	49,1

Figura 26 – Resumo de setembro/2025 para o Subsistema Norte

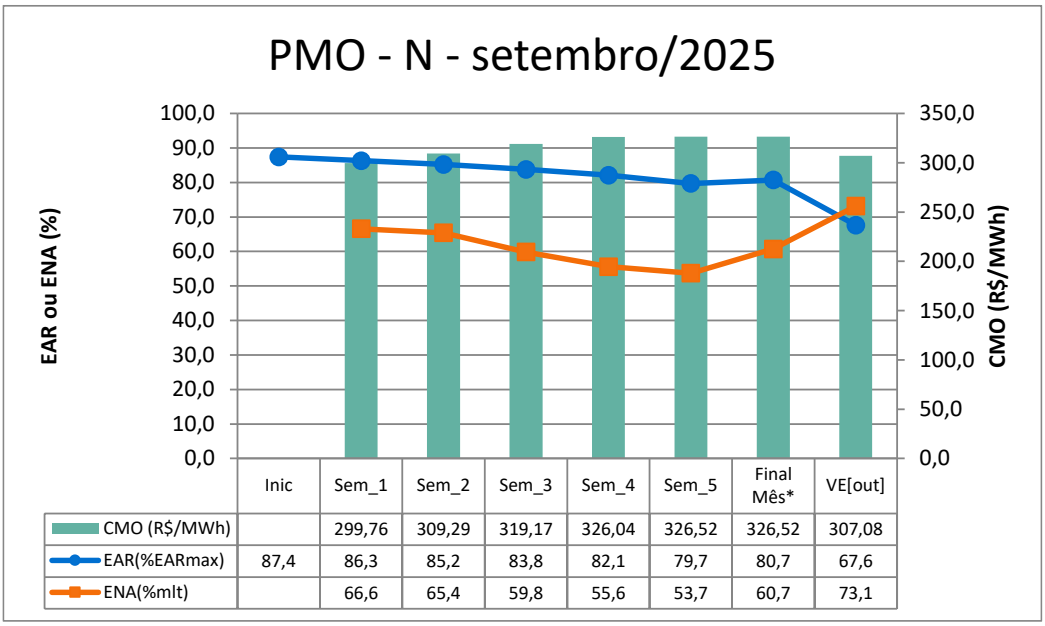

	Inic	Sem_1	Sem_2	Sem_3	Sem_4	Sem_5	Final Mês*	VE[out]
CMO (R$/MWh)		299,76	309,29	319,17	326,04	326,52	326,52	307,08
EAR(%EARmax)	87,4	86,3	85,2	83,8	82,1	79,7	80,7	67,6
ENA(%mlt)		66,6	65,4	59,8	55,6	53,7	60,7	73,1

O conteúdo desta publicação foi produzido pelo ONS com base em dados e informações de conhecimento público. É de responsabilidade exclusiva dos agentes e demais interessados a obtenção de outros dados e informações, a realização de análises, estudos e avaliações para fins de tomada de decisões, definição de estratégias de atuação, assunção de compromissos e obrigações e quaisquer outras finalidades, em qualquer tempo e sob qualquer condição. É proibida a reprodução ou utilização total ou parcial do presente sem a identificação da fonte.

7. ARMAZENAMENTOS OPERATIVOS

Para uma melhor avaliação de diversos cenários hidrometeorológicos, notadamente, aqueles de curto prazo e suas influências nas previsões de vazões nos subsistemas, os resultados deste PMO contemplam cenários de afluências visando melhor representar a ocorrência de precipitação e, consequentemente, seus efeitos sobre as afluências e armazenamentos.

Apresentamos a seguir as correspondentes energias naturais afluentes e os resultados obtidos com a aplicação do cenário de afluência utilizado no estudo.

Tabela 10 – Previsão de ENA do caso de valor esperado das previsões de afluência

Subsistema	ENERGIAS NATURAIS AFLUENTES			
	Previsão Semanal		Previsão Mensal	
	(MWmed)	%MLT	(MWmed)	%MLT
SE/CO	12.320	62	12.022	61
Sul	10.864	97	12.692	109
Nordeste	1.378	46	1.366	47
Norte	1.609	64	1.372	61

Tabela 11 – Previsão de %EARmáx para o final do mês

Subsistema	% EARmáx 29/08	% EARmáx - 30/09
	NÍVEL INICIAL	NÍVEL PMO
SE/CO	58,1	52,4
Sul	87,3	82,1
Nordeste	60,1	53,8
Norte	87,4	80,7

O conteúdo desta publicação foi produzido pelo ONS com base em dados e informações de conhecimento público. É de responsabilidade exclusiva dos agentes e demais interessados a obtenção de outros dados e informações, a realização de análises, estudos e avaliações para fins de tomada de decisões, definição de estratégias de atuação, assunção de compromissos e obrigações e quaisquer outras finalidades, em qualquer tempo e sob qualquer condição. É proibida a reprodução ou utilização total ou parcial do presente sem a identificação da fonte.

8. RESERVATÓRIOS EQUIVALENTES DE ENERGIA

A seguir são apresentadas as previsões de Energia Natural Afluente para a próxima semana operativa e para o mês de setembro, bem como as previsões de Energia Armazenada nos Reservatórios Equivalentes de Energia – REE, deste PMO de Setembro de 2025.

Tabela 12 – Previsão de ENA por REE

Valor Esperado das Energias Naturais Afluentes				
REE	Previsão Semanal		Previsão Mensal	
	30/08/2025 a 05/09/2025		set/25	
	(MWmed)	%MLT	(MWmed)	%MLT
Sudeste	1.391	56	1.371	56
Madeira	1.509	77	1.350	76
Teles Pires	480	66	452	64
Itaipu	1.933	73	1.921	72
Paraná	5.787	57	5.710	57
Paranapanema	743	37	795	39
Sul	6.071	91	8.656	124
Iguaçu	4.792	107	4.035	86
Nordeste	1.378	46	1.366	47
Norte	897	57	811	55
Belo Monte	292	63	191	51
Manaus	490	99	396	94

Tabela 13 – Previsão de %EARmáx por REE

% Energia Armazenável Máxima		
REE	Previsão Semanal	Previsão Mensal
	05-set	30-set
	(%EARmáx)	(%EARmáx)
Sudeste	61,2	58,3
Madeira	39,1	28,6
Teles Pires	68,7	39,4
Itaipu	59,0	100,0
Paraná	55,8	50,5
Paranapanema	55,7	47,9
Sul	79,4	86,4
Iguaçu	89,4	78,0
Nordeste	58,9	53,8
Norte	86,4	81,2
Belo Monte	100,0	97,7
Manaus	84,2	70,6

O conteúdo desta publicação foi produzido pelo ONS com base em dados e informações de conhecimento público. É de responsabilidade exclusiva dos agentes e demais interessados a obtenção de outros dados e informações, a realização de análises, estudos e avaliações para fins de tomada de decisões, definição de estratégias de atuação, assunção de compromissos e obrigações e quaisquer outras finalidades, em qualquer tempo e sob qualquer condição. É proibida a reprodução ou utilização total ou parcial do presente sem a identificação da fonte.

9. DESPACHO TÉRMICO POR MODALIDADE, PATAMAR DE CARGA E USINA

Nas tabelas abaixo, a diferenciação entre geração por inflexibilidade e por ordem de mérito tem caráter informativo, com o objetivo de detalhar a informação de inflexibilidade enviada pelos respectivos agentes para o PMO. Ressalta-se que nas etapas de Programação Diária e Tempo Real, o montante despachado nas usinas termelétricas indicadas por ordem de mérito é plenamente intitulado como ordem de mérito.

REGIÃO SUDESTE/CENTRO-OESTE

Térmicas Potência (MW)	Combustível	CVU (R$/MWh)	Inflexibilidade			Ordem de Mérito			Total Mérito e INFL.			Razão Elétrica			Total UTE		
			P	M	L	P	M	L	P	M	L	P	M	L	P	M	L
ATLAN_CSA (255)	Resíduos	0,00	112,9	112,9	112,9				112,9	112,9	112,9				112,9	112,9	112,9
DAIA (44)	Diesel	---															
TNORTE 2 (349)	Óleo	---															
W.ARJONA O (177)	Diesel	---															
XAVANTES (54)	Diesel	---															
ANGRA 2 (1350)	Nuclear	20,12	1350,0	1350,0	1350,0	0,0	0,0	0,0	1350,0	1350,0	1350,0				1350,0	1350,0	1350,0
ANGRA 1 (640)	Nuclear	31,17	640,0	640,0	640,0	0,0	0,0	0,0	640,0	640,0	640,0				640,0	640,0	640,0
O.PINTADA (50)	Biomassa	145,52				50,0	50,0	50,0	50,0	50,0	50,0				50,0	50,0	50,0
M.AZUL (566)	Gás	147,17				565,5	565,5	565,5	565,5	565,5	565,5				565,5	565,5	565,5
UTE STA VI (41)	Biomassa	157,20	18,0	18,0	18,0	23,0	23,0	23,0	41,0	41,0	41,0				41,0	41,0	41,0
BAIXADA FL (530)	Gás	213,84				530,0	530,0	530,0	530,0	530,0	530,0				530,0	530,0	530,0
SANTA CRUZ (500)	GNL	217,45				350,0	350,0	350,0	350,0	350,0	350,0				350,0	350,0	350,0
ATLANTICO (235)	Resíduos	262,54	218,7	218,7	218,7	0,0	0,0	0,0	218,7	218,7	218,7				218,7	218,7	218,7
ST.CRUZ 34 (436)	Óleo	310,41															
LUIZORMELO (204)	GNL	327,91															
UTE GNA I (1338)	Gás	413,87															
CUBATAO (216)	Gás	428,49	209,0	209,0	209,0				209,0	209,0	209,0				209,0	209,0	209,0
UTE GNA II (1673)	Gás	557,81	1672,0	1672,0	1672,0				1672,0	1672,0	1672,0				1672,0	1672,0	1672,0
KARKEY 013 (259)	Gás	873,10	31,0	31,0	31,0				31,0	31,0	31,0				31,0	31,0	31,0
KARKEY 019 (116)	Gás	873,10															
T.LAGOAS (350)	Gás	914,65	180,0	180,0	180,0				180,0	180,0	180,0				180,0	180,0	180,0
T.MACAE (922)	Gás	958,70	108,0	189,0	332,9				108,0	189,0	332,9				108,0	189,0	332,9
PORSUD II (78)	Gás	1022,22															
PORSUD I (116)	Gás	1022,73															
CUIABA CC (529)	Gás	1042,35															
W.ARJONA (177)	Gás	1047,10															
IBIRITE (235)	Gás	1047,48															
TERMORIO (989)	Gás	1051,19	600,0	600,0	600,0				600,0	600,0	600,0				600,0	600,0	600,0
NORTEFLU (826)	Gás	1171,22															
VIANA (175)	Óleo	1183,29															
SEROPEDICA (360)	Gás	1241,29		66,0	152,9					66,0	152,9				0,0	66,0	152,9
PAULINIA (16)	Gás	1246,17	15,7	15,7	15,7				15,7	15,7	15,7				15,7	15,7	15,7
J.FORA (87)	Gás	1250,88		15,4	35,7					15,4	35,7				0,0	15,4	35,7
LORM_PCS (36)	Gás	1269,04															
POVOACAO I (75)	Gás	1269,04															
VIANA I (37)	Gás	1269,04															
PALMEIR_GO (176)	Diesel	1439,40															
NPIRATINGA (572)	Gás	1508,95	76,0	88,7	197,8				76,0	88,7	197,8				76,0	88,7	197,8
TOTAL SE/CO (14789)			5231,3	5406,4	5766,6	1518,5	1518,5	1518,5	6749,8	6924,9	7285,1	0,0	0,0	0,0	6749,8	6924,9	7285,1

REGIÃO SUL

Térmicas Potência (MW)	Combustível	CVU (R$/MWh)	Inflexibilidade			Ordem de Mérito			Total Mérito e INFL.			Razão Elétrica			Total UTE		
			P	M	L	P	M	L	P	M	L	P	M	L	P	M	L
PAMPA SUL (345)	Carvão	101,20	310,0	310,0	310,0	35,0	35,0	35,0	345,0	345,0	345,0				345,0	345,0	345,0
SAO SEPE (8)	Biomassa	113,53				8,0	8,0	8,0	8,0	8,0	8,0				8,0	8,0	8,0
FIGUEIRA (20)	Carvão	330,64															
J.LACER. C (330)	Carvão	341,04	300,0	300,0	300,0				300,0	300,0	300,0				300,0	300,0	300,0
J.LACER. B (220)	Carvão	397,24	220,0	220,0	220,0				220,0	220,0	220,0				220,0	220,0	220,0
J.LAC. A2 (110)	Carvão	406,63	110,0	110,0	110,0				110,0	110,0	110,0				110,0	110,0	110,0
J.LAC. A1 (80)	Carvão	475,13															
CANDIOTA_3 (350)	Carvão	523,55	320,0	320,0	320,0				320,0	320,0	320,0				320,0	320,0	320,0
B.BONITA I (10)	Gás	778,35															
ARAUCARIA (484)	Gás	780,33															
URUGUAIANA (640)	Gás	824,70															
CANOAS (249)	Gás	1356,06															
TOTAL SUL (2846)			1260,0	1260,0	1260,0	43,0	43,0	43,0	1303,0	1303,0	1303,0	0,0	0,0	0,0	1303,0	1303,0	1303,0

O conteúdo desta publicação foi produzido pelo ONS com base em dados e informações de conhecimento público. É de responsabilidade exclusiva dos agentes e demais interessados a obtenção de outros dados e informações, a realização de análises, estudos e avaliações para fins de tomada de decisões, definição de estratégias de atuação, assunção de compromissos e obrigações e quaisquer outras finalidades, em qualquer tempo e sob qualquer condição. É proibida a reprodução ou utilização total ou parcial do presente sem a identificação da fonte.

REGIÃO NORDESTE

Térmicas Potência (MW)	Combustível	CVU (R$/MWh)	Inflexibilidade			Ordem de Mérito			Total Mérito e INFL.			Razão Elétrica			Total UTE		
			P	M	L	P	M	L	P	M	L	P	M	L	P	M	L
GLOBAL I (149)	Óleo	---															
GLOBAL II (149)	Óleo	---															
MARACANAU (168)	Óleo	---															
PETROLINA (136)	Óleo	---															
POTIGUAR (53)	Diesel	---															
POTIGUAR_3 (66)	Diesel	---															
TERMOCABO (50)	Óleo	---															
ERB CANDEI (17)	Biomassa	113,61	3,5	3,5	3,5	8,5	8,5	8,5	12,0	12,0	12,0				12,0	12,0	12,0
PROSP_I (28)	Gás	214,28				9,3	12,4	13,9	9,3	12,4	13,9				9,3	12,4	13,9
PROSP_III (56)	Gás	218,33				56,0	56,0	56,0	56,0	56,0	56,0				56,0	56,0	56,0
P.PECEM1 (720)	Carvão	326,87															
PROSP_II (37)	Gás	326,98															
P.PECEM2 (365)	Carvão	335,39															
PSERGIPE I (1593)	GNL	335,71															
VALE ACU (110)	Gás	450,86															
PERNAMBU_3 (201)	Óleo	905,08															
TERMOPE (550)	Gás	926,55															
SUAPE II (381)	Óleo	1072,13															
T.BAHIA (186)	Gás	1084,81															
TERMONE (171)	Óleo	2040,70															
TERMOPB (171)	Óleo	2040,70															
TERMOCEARA (223)	Óleo	2181,47															
CAMPINA_GR (169)	Óleo	2272,16															
C.MURICY 2 (144)	Óleo	2651,30															
PECEM 2 (144)	Óleo	2679,02															
TOTAL NE (5749)			3,5	3,5	3,5	73,8	76,9	78,4	77,3	80,4	81,9	0,0	0,0	0,0	77,3	80,4	81,9

REGIÃO NORTE

Térmicas Potência (MW)	Combustível	CVU (R$/MWh)	Inflexibilidade			Ordem de Mérito			Total Mérito e INFL.			Razão Elétrica			Total UTE		
			P	M	L	P	M	L	P	M	L	P	M	L	P	M	L
BBF BALIZA (18)	Biomassa	---															
BONFIM (12)	Biomassa	---															
CANTA (12)	Biomassa	---															
JAGUATI II (141)	Gás	---															
M.C.SUCUBA (42)	Diesel	---															
PALMAPLAN (12)	Biomassa	---															
PAU RAINHA (12)	Biomassa	---															
SANTA LUZ (12)	Biomassa	---															
APARECIDA (166)	Gás	109,03	75,0	75,0	75,0	73,0	73,0	73,0	148,0	148,0	148,0				148,0	148,0	148,0
JARAQUI (75)	Gás	109,03	29,0	29,0	29,0	34,0	34,0	34,0	63,0	63,0	63,0				63,0	63,0	63,0
PIRARUCU (73)	Gás	109,03	35,0	35,0	35,0	32,0	32,0	32,0	67,0	67,0	67,0				67,0	67,0	67,0
PORAQUE (85)	Gás	109,03	28,0	28,0	28,0	39,0	39,0	39,0	67,0	67,0	67,0				67,0	67,0	67,0
TAMBAQUI (93)	Gás	109,03	33,0	33,0	33,0	30,0	30,0	30,0	63,0	63,0	63,0				63,0	63,0	63,0
TUCUNARE (73)	Gás	109,03	35,0	35,0	35,0	29,0	29,0	29,0	64,0	64,0	64,0				64,0	64,0	64,0
UTE MAUA 3 (591)	Gás	109,03	264,0	264,0	264,0	115,1	83,5	34,1	379,1	347,5	298,1				379,1	347,5	298,1
MARANHAO3 (519)	Gás	110,91	490,0	490,0	490,0	8,2	13,9	23,2	498,2	503,9	513,2				498,2	503,9	513,2
MARANHAO V (338)	Gás	201,63				328,6	331,0	335,1	328,6	331,0	335,1				328,6	331,0	335,1
MARANHAOIV (338)	Gás	201,63				328,6	331,0	335,1	328,6	331,0	335,1				328,6	331,0	335,1
PARNAIBA_V (386)	Vapor	227,82				239,0	239,0	239,0	239,0	239,0	239,0				239,0	239,0	239,0
N.VENECIA2 (270)	Gás	294,56	180,0	180,0	180,0	79,5	81,1		259,5	261,1	180,0				259,5	261,1	180,0
P. ITAQUI (360)	Carvão	327,49															
PARNAIB_IV (56)	Gás	465,01															
GERAMAR2 (166)	Óleo	1985,61															
GERAMAR1 (166)	Óleo	2010,92															
TOTAL NORTE (4303)			1169,0	1169,0	1169,0	1336,0	1316,5	1203,5	2505,0	2485,5	2372,5	0,0	0,0	0,0	2505,0	2485,5	2372,5

O conteúdo desta publicação foi produzido pelo ONS com base em dados e informações de conhecimento público. É de responsabilidade exclusiva dos agentes e demais interessados a obtenção de outros dados e informações, a realização de análises, estudos e avaliações para fins de tomada de decisões, definição de estratégias de atuação, assunção de compromissos e obrigações e quaisquer outras finalidades, em qualquer tempo e sob qualquer condição. É proibida a reprodução ou utilização total ou parcial do presente sem a identificação da fonte.