1. APRESENTAÇÃO

No mês de janeiro houve precipitação nas bacias dos rios Paranaíba, Doce e São Francisco. Nas demais bacias hidrográficas de interesse do SIN apesar da ocorrência de precipitação, os totais observados foram inferiores à média mensal.

Na semana de 24/01 a 30/01/2026, houve precipitação nas bacias dos rios Paranaíba, Tocantins, Xingu, Tapajós e Madeira.

Na semana de 31/01 a 06/02/2026, deve ocorrer precipitação nas bacias dos rios Tietê, Grande, Paranaíba e cabeceira do São Francisco, com os valores ficando entre a média e acima da média semanal.

Os valores médios semanais do Custo Marginal de Operação – CMO dos subsistemas do SIN sofreram as seguintes alterações em relação à semana anterior:

- SE/CO: de R$ 308,90/MWh para R$ 322,62/MWh
- Sul: de R$ 309,74/MWh para R$ 322,62/MWh
- Nordeste: de R$ 177,28/MWh para R$ 322,62/MWh
- Norte: de R$ 289,25/MWh para R$ 322,62/MWh

Desde o dia 01/01/2020, o despacho por ordem de mérito é indicado diariamente pelos resultados do modelo DESSEM. Assim, o despacho por ordem de mérito semanal, conforme publicado nesse documento, tem caráter apenas informativo. Da mesma forma, desde o dia 01/01/2021, a formação de preço deixou o formato semanal/patamar de carga e passou a ser horário, de acordo também com os resultados do modelo DESSEM.

2. NOTÍCIAS

Nos dias 26 e 27 de fevereiro será realizada a reunião de elaboração do PMO de Março de 2026, com transmissão ao vivo através do site do ONS.

3. INFORMAÇÕES CONJUNTURAIS PARA ELABORAÇÃO DO PMO

3.1. Informações hidrometeorológicas

3.1.1. Condições antecedentes

No mês de janeiro, a configuração de dois episódios da Zona de Convergência do Atlântico Sul (ZCAS) favoreceu a ocorrência de precipitação superior à média mensal nas bacias dos rios Paranaíba, Doce e São Francisco. Nas demais bacias hidrográficas de interesse do SIN apesar da ocorrência de precipitação, os totais observados foram inferiores à média mensal (Figura 1).

O conteúdo desta publicação foi produzido pelo ONS com base em dados e informações de conhecimento público. É de responsabilidade exclusiva dos agentes e demais interessados a obtenção de outros dados e informações, a realização de análises, estudos e avaliações para fins de tomada de decisões, definição de estratégias de atuação, assunção de compromissos e obrigações e quaisquer outras finalidades, em qualquer tempo e sob qualquer condição. É proibida a reprodução ou utilização total ou parcial do presente sem a identificação da fonte.

Figura 1 - Mapa de anomalia da precipitação acumulada (mm) – Janeiro/2026

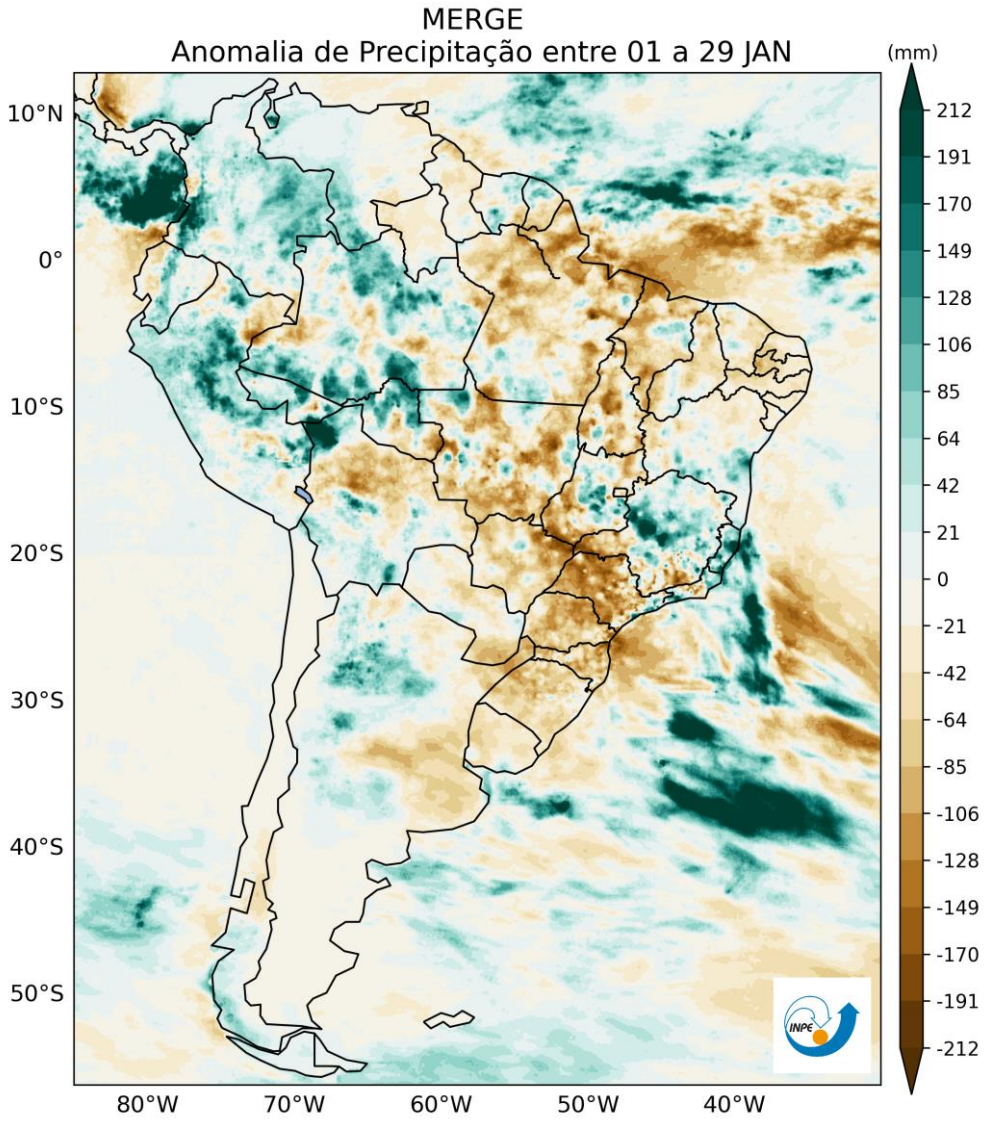

Fonte: Centro de Previsão de Tempo e Estudos Climáticos - CPTEC.

A semana em curso iniciou com a permanência da atuação da ZCAS nas Regiões Sudeste e Centro-Oeste. Com a desconfiguração da ZCAS, a precipitação reduziu nessas regiões, apresentando totais inferiores aos observados na semana passada. As bacias hidrográficas da Região Norte apresentaram pancadas de chuva no decorrer da semana. Os maiores totais de precipitação foram observados nas bacias dos rios Paranaíba, Tocantins, Xingu, Tapajós e Madeira (Figura 2).

O conteúdo desta publicação foi produzido pelo ONS com base em dados e informações de conhecimento público. É de responsabilidade exclusiva dos agentes e demais interessados a obtenção de outros dados e informações, a realização de análises, estudos e avaliações para fins de tomada de decisões, definição de estratégias de atuação, assunção de compromissos e obrigações e quaisquer outras finalidades, em qualquer tempo e sob qualquer condição. É proibida a reprodução ou utilização total ou parcial do presente sem a identificação da fonte.

Figura 2 - Precipitação observada (mm) no período de 24 a 29/01/2026

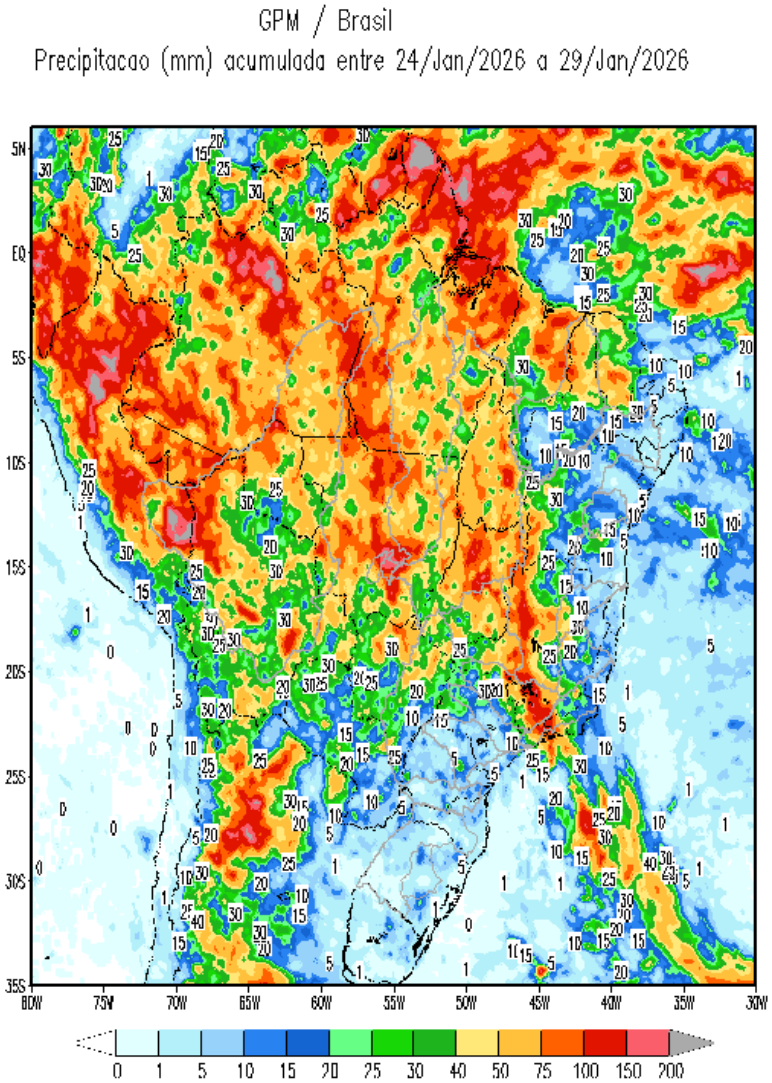

A Tabela 1 apresenta as energias naturais afluentes das semanas recentes. São apresentados os valores verificados na semana 17/01/2026 a 23/01/2026 e os estimados para fechamento da semana de 24/01/2026 a 30/01/2026.

Tabela 1 – Tendência hidrológica da ENA do PMO de Fevereiro/2026

PMO de Fevereiro/2026 - ENAs verificadas e estimadas				
Subsistema	17/01 a 23/01/2026		24/01 a 30/01/2026	
	MWmed	%MLT	MWmed	%MLT
SE/CO	40.726	62	54.702	83
S	5.565	74	3.483	46
NE	6.003	45	7.123	53
N	10.479	66	10.677	68

O conteúdo desta publicação foi produzido pelo ONS com base em dados e informações de conhecimento público. É de responsabilidade exclusiva dos agentes e demais interessados a obtenção de outros dados e informações, a realização de análises, estudos e avaliações para fins de tomada de decisões, definição de estratégias de atuação, assunção de compromissos e obrigações e quaisquer outras finalidades, em qualquer tempo e sob qualquer condição. É proibida a reprodução ou utilização total ou parcial do presente sem a identificação da fonte.

3.1.2. Climatologia para o trimestre fevereiro-março-abril

Para o trimestre fevereiro-março-abril (FMA) de 2026, o cenário mais provável é de precipitação em torno da média nas principais bacias do SIN.

Climatologicamente, o trimestre FMA é caracterizado pelo fim do período chuvoso nas bacias dos subsistemas Nordeste e Sudeste-Centro-Oeste (Figura 3).

Figura 3 - Climatologia de precipitação para o trimestre fevereiro-março-abril

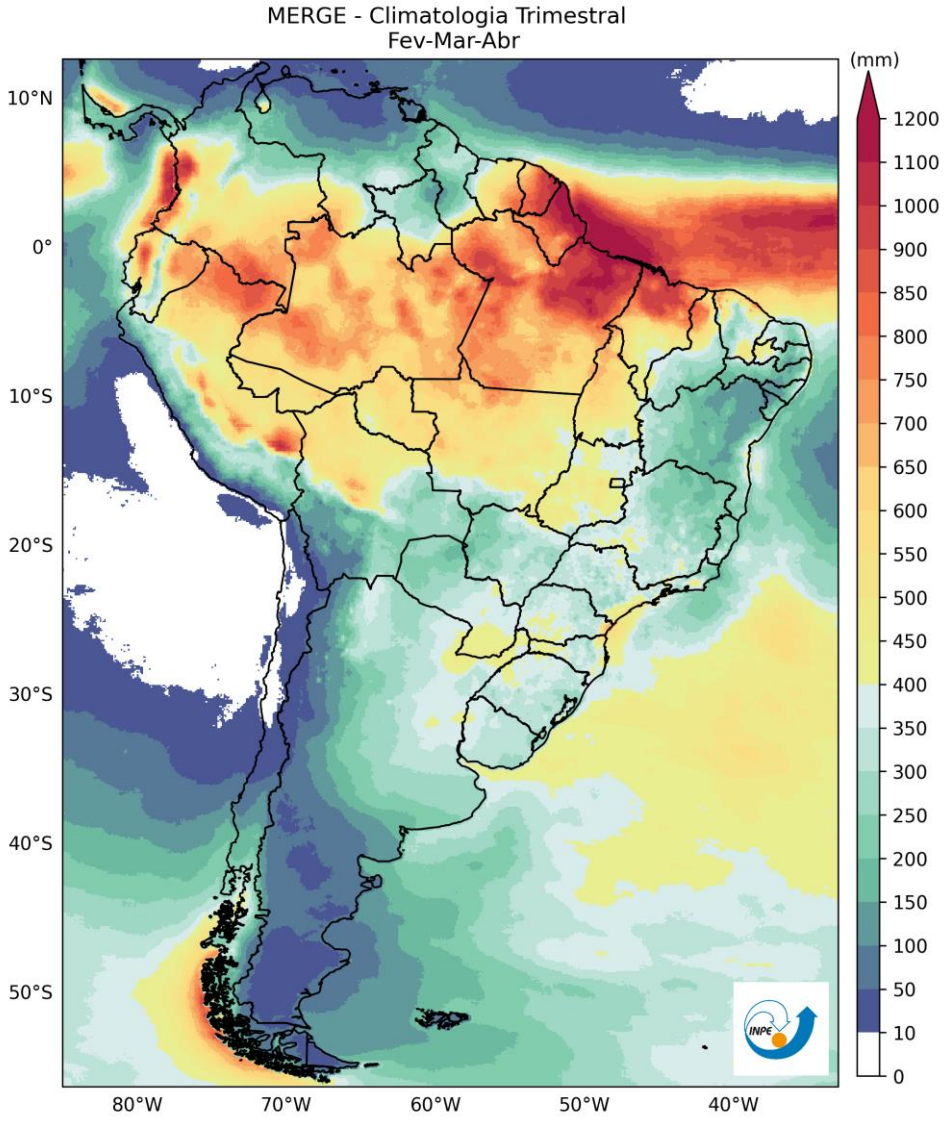

Fonte: Centro de Previsão de Tempo e Estudos Climáticos - CPTEC.

O conteúdo desta publicação foi produzido pelo ONS com base em dados e informações de conhecimento público. É de responsabilidade exclusiva dos agentes e demais interessados a obtenção de outros dados e informações, a realização de análises, estudos e avaliações para fins de tomada de decisões, definição de estratégias de atuação, assunção de compromissos e obrigações e quaisquer outras finalidades, em qualquer tempo e sob qualquer condição. É proibida a reprodução ou utilização total ou parcial do presente sem a identificação da fonte.

3.1.3. Previsão para a próxima semana

Na próxima semana operativa a atuação de dois sistemas de baixa pressão no litoral da Região Sudeste ocasionará precipitação nas bacias dessa região. As bacias hidrográficas da Região Norte apresentam pancadas de chuva no decorrer da próxima semana. Os maiores totais de precipitação estão previstos para as bacias dos rios Tietê, Grande, Paranaíba e cabeceira do São Francisco, com os valores ficando entre a média e acima da média semanal (Figura 4).

Figura 4 - Precipitação acumulada prevista pelo modelo ECMWF - período de 31/01 a 06/02/2026

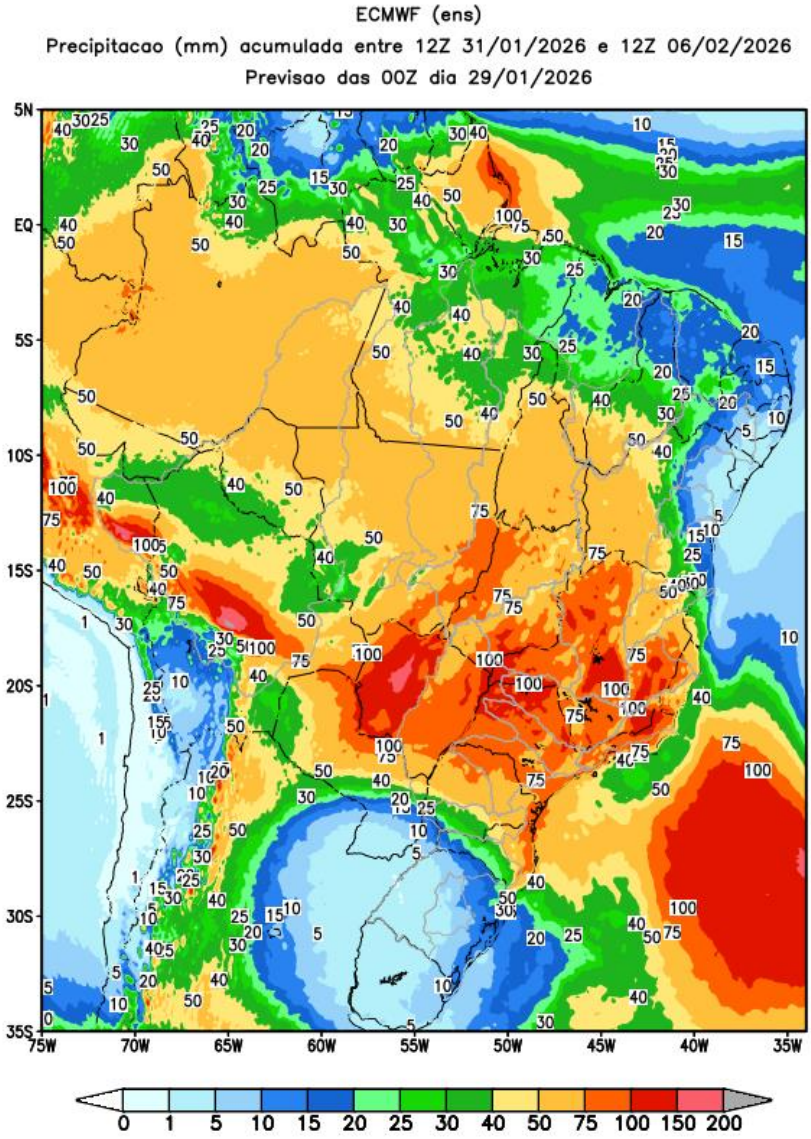

Em comparação com os valores estimados para a semana em curso, prevê-se para a próxima semana operativa ascensão nas afluências dos subsistemas Sudeste/Centro-Oeste, Nordeste e Norte e recessão nas afluências do subsistema Sul. A previsão mensal para fevereiro indica a ocorrência de afluências abaixo da média histórica para os subsistemas Sudeste/Centro-Oeste, Sul e Norte e na média histórica para o subsistema Nordeste.

O conteúdo desta publicação foi produzido pelo ONS com base em dados e informações de conhecimento público. É de responsabilidade exclusiva dos agentes e demais interessados a obtenção de outros dados e informações, a realização de análises, estudos e avaliações para fins de tomada de decisões, definição de estratégias de atuação, assunção de compromissos e obrigações e quaisquer outras finalidades, em qualquer tempo e sob qualquer condição. É proibida a reprodução ou utilização total ou parcial do presente sem a identificação da fonte.

Tabela 2 – Previsão de ENAs do PMO de Fevereiro/2026

PMO de Fevereiro/2026 - ENAs previstas				
Subsistema	31/01 a 06/02/2026		Mês de fevereiro	
	MWmed	%MLT	MWmed	%MLT
SE/CO	65.790	94	64.239	91
S	3.195	39	3.775	46
NE	8.663	62	14.415	102
N	12.209	56	16.190	71

As figuras a seguir ilustram as ENAs semanais previstas no PMO de Fevereiro/2026.

Figura 5 - Energias Naturais Afluentes ao Subsistema Sudeste/Centro-Oeste do PMO de Fevereiro/2026

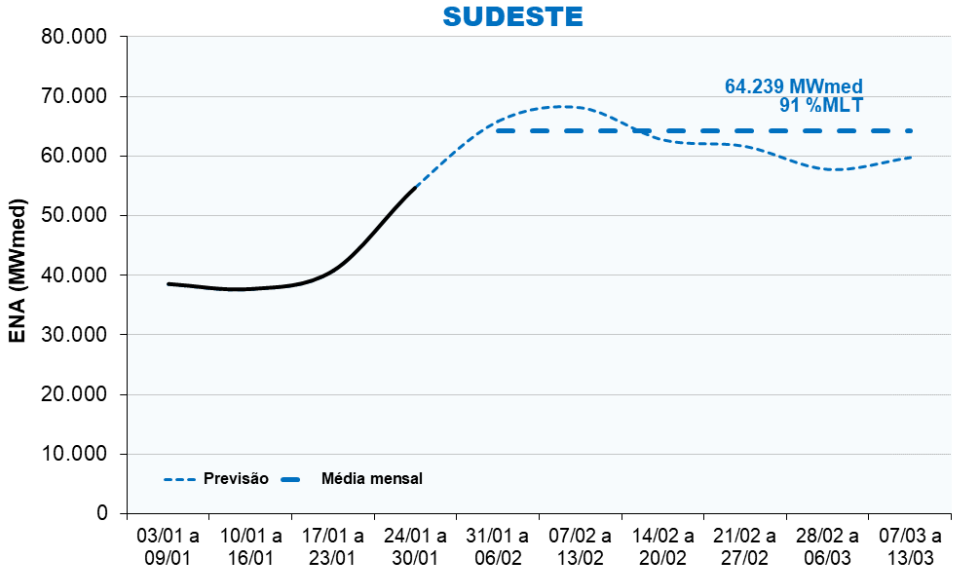

Figura 6 - Energias Naturais Afluentes ao Subsistema Sul do PMO de Fevereiro/2026

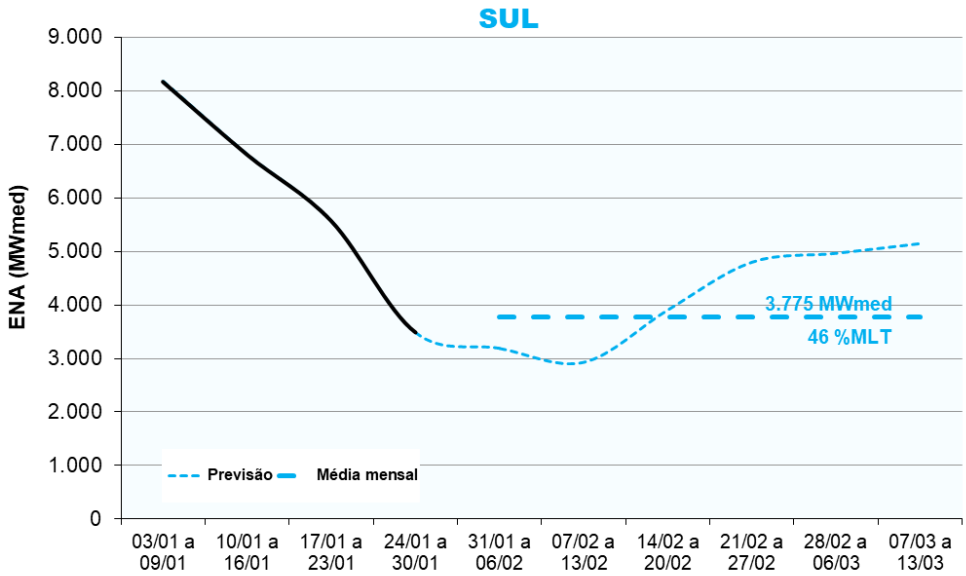

O conteúdo desta publicação foi produzido pelo ONS com base em dados e informações de conhecimento público. É de responsabilidade exclusiva dos agentes e demais interessados a obtenção de outros dados e informações, a realização de análises, estudos e avaliações para fins de tomada de decisões, definição de estratégias de atuação, assunção de compromissos e obrigações e quaisquer outras finalidades, em qualquer tempo e sob qualquer condição. É proibida a reprodução ou utilização total ou parcial do presente sem a identificação da fonte.

Figura 7 - Energias Naturais Afluentes ao Subsistema Nordeste do PMO de Fevereiro/2026

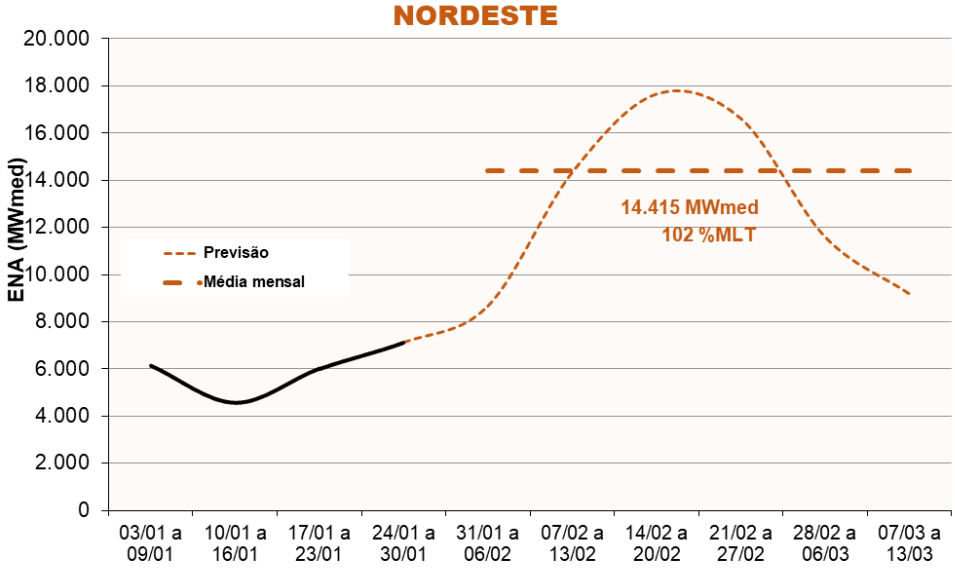

Figura 8 - Energias Naturais Afluentes ao Subsistema Norte do PMO de Fevereiro/2026

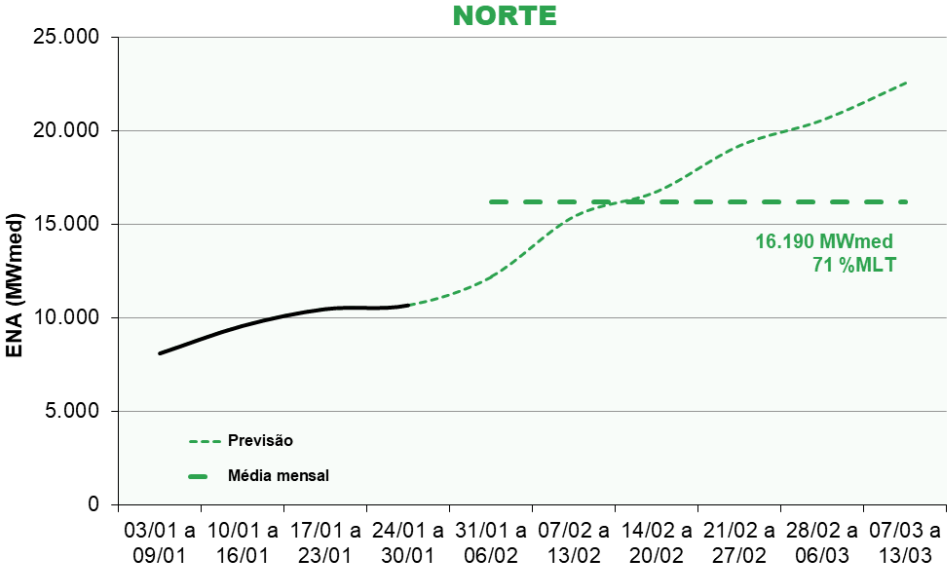

O conteúdo desta publicação foi produzido pelo ONS com base em dados e informações de conhecimento público. É de responsabilidade exclusiva dos agentes e demais interessados a obtenção de outros dados e informações, a realização de análises, estudos e avaliações para fins de tomada de decisões, definição de estratégias de atuação, assunção de compromissos e obrigações e quaisquer outras finalidades, em qualquer tempo e sob qualquer condição. É proibida a reprodução ou utilização total ou parcial do presente sem a identificação da fonte.

3.1.4. Cenários de ENAs para o PMO de Fevereiro/2026

As figuras a seguir apresentam as características dos cenários de energias naturais afluentes gerados no PMO de Fevereiro/2026, para acoplamento com a FCF do mês de março/2026. São mostradas, para os quatro subsistemas, as amplitudes e as Funções de Distribuição Acumulada dos cenários de ENA.

Figura 9 - Amplitude dos Cenários de ENA para o Subsistema Sudeste/Centro-Oeste, em %MLT, para o PMO de Fevereiro/2026

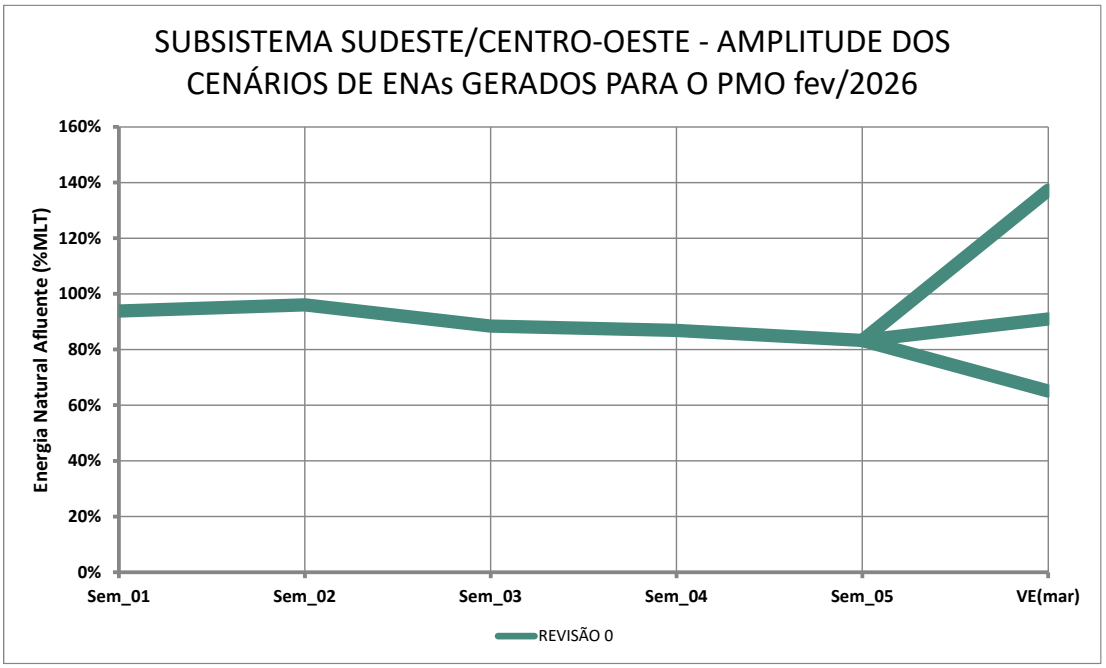

Figura 10 - Função de Distribuição Acumulada dos Cenários para o Subsistema Sudeste/Centro-Oeste para o PMO de Fevereiro/2026

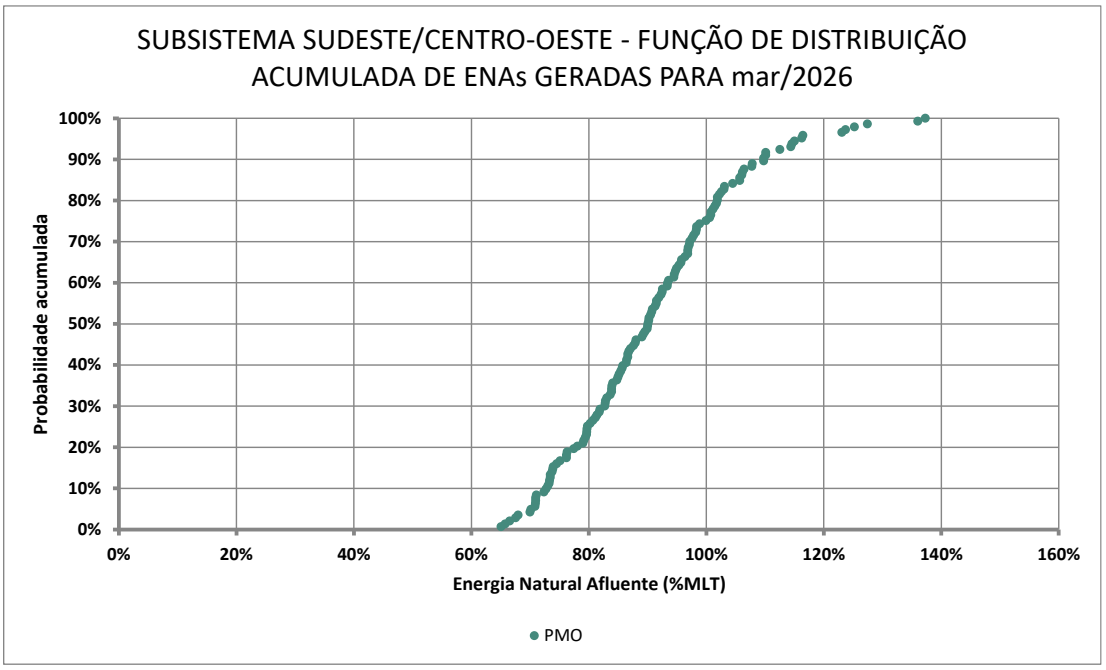

O conteúdo desta publicação foi produzido pelo ONS com base em dados e informações de conhecimento público. É de responsabilidade exclusiva dos agentes e demais interessados a obtenção de outros dados e informações, a realização de análises, estudos e avaliações para fins de tomada de decisões, definição de estratégias de atuação, assunção de compromissos e obrigações e quaisquer outras finalidades, em qualquer tempo e sob qualquer condição. É proibida a reprodução ou utilização total ou parcial do presente sem a identificação da fonte.

Figura 11 - Amplitude dos Cenários de ENA para o Subsistema Sul, em %MLT, para o PMO de Fevereiro/2026

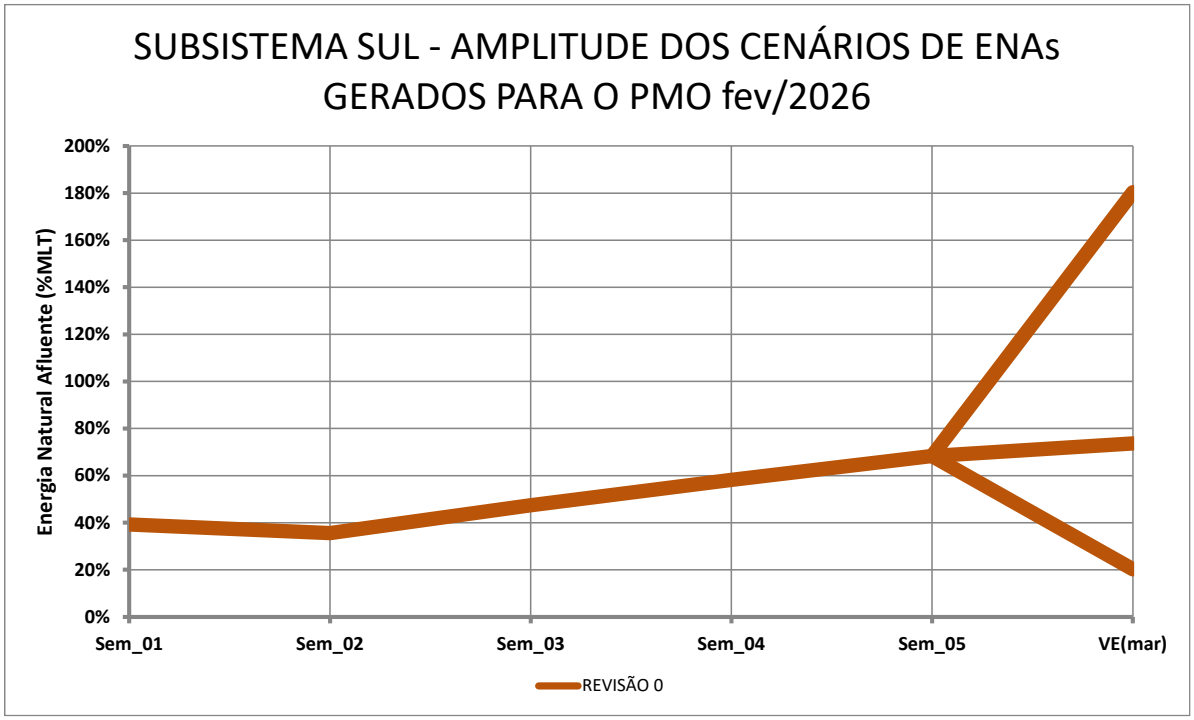

Figura 12 - Função de Distribuição Acumulada dos Cenários para o Subsistema Sul para o PMO de Fevereiro/2026

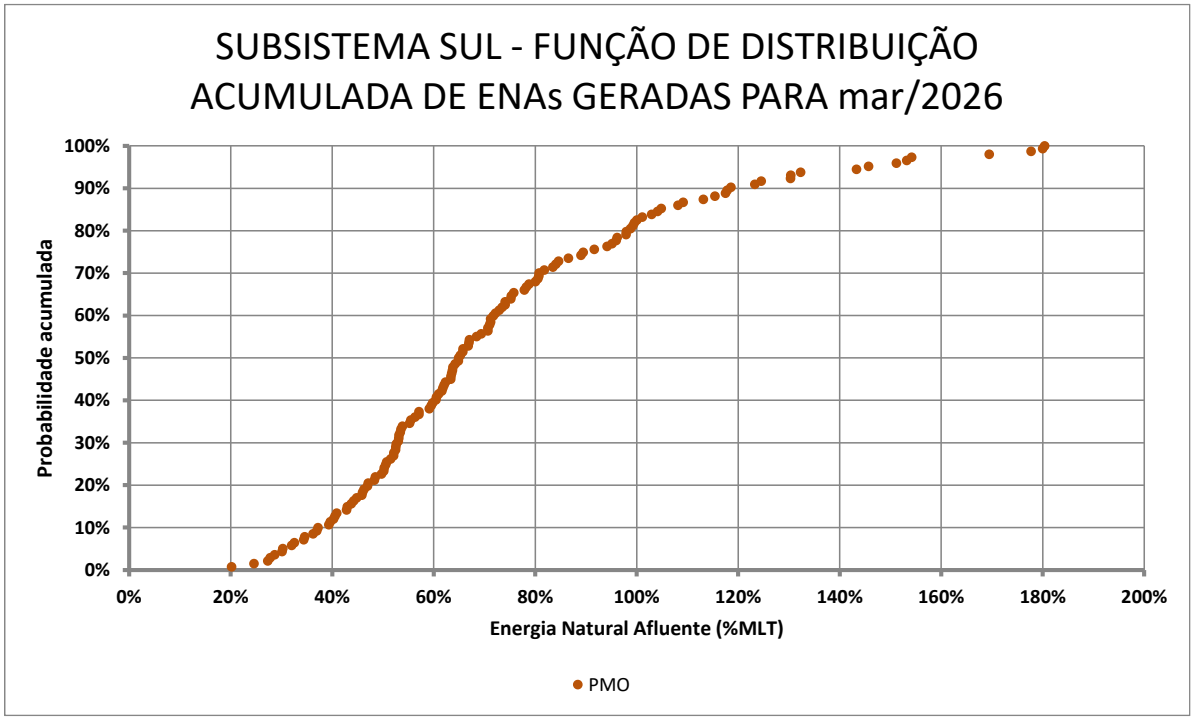

O conteúdo desta publicação foi produzido pelo ONS com base em dados e informações de conhecimento público. É de responsabilidade exclusiva dos agentes e demais interessados a obtenção de outros dados e informações, a realização de análises, estudos e avaliações para fins de tomada de decisões, definição de estratégias de atuação, assunção de compromissos e obrigações e quaisquer outras finalidades, em qualquer tempo e sob qualquer condição. É proibida a reprodução ou utilização total ou parcial do presente sem a identificação da fonte.

Figura 13 - Amplitude dos Cenários de ENA para o Subsistema Nordeste em %MLT, para o PMO de Fevereiro/2026

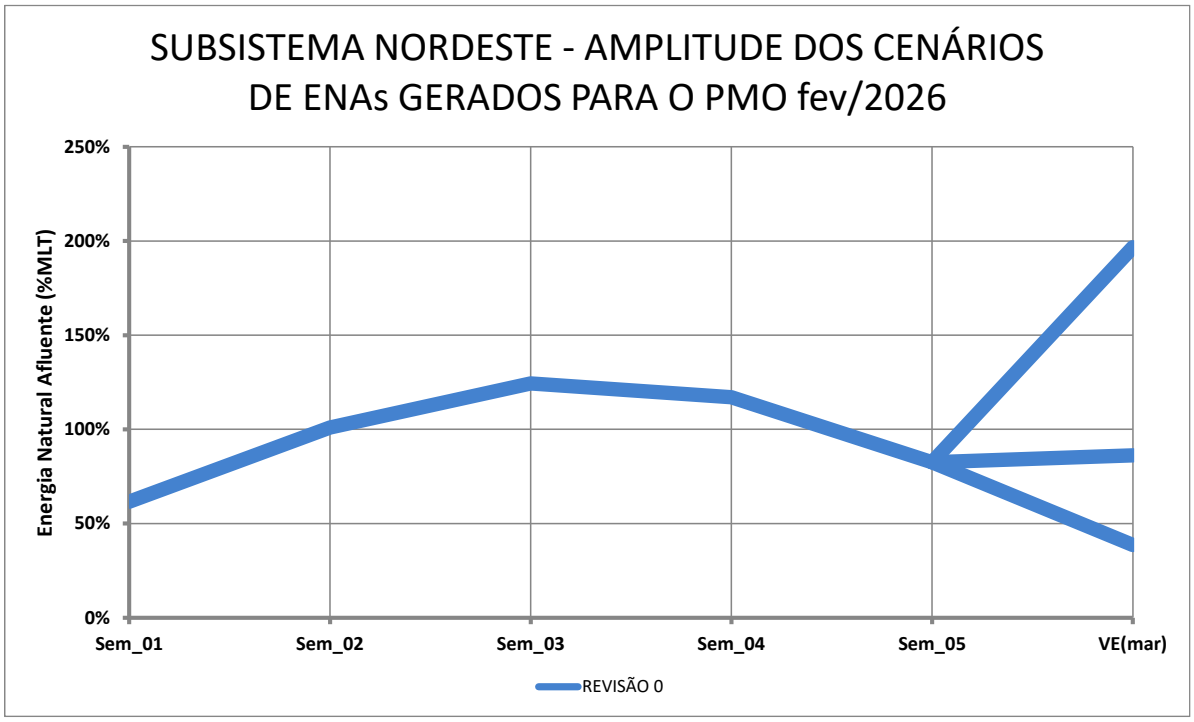

Figura 14 - Função de Distribuição Acumulada dos Cenários para o Subsistema Nordeste para o PMO de Fevereiro/2026

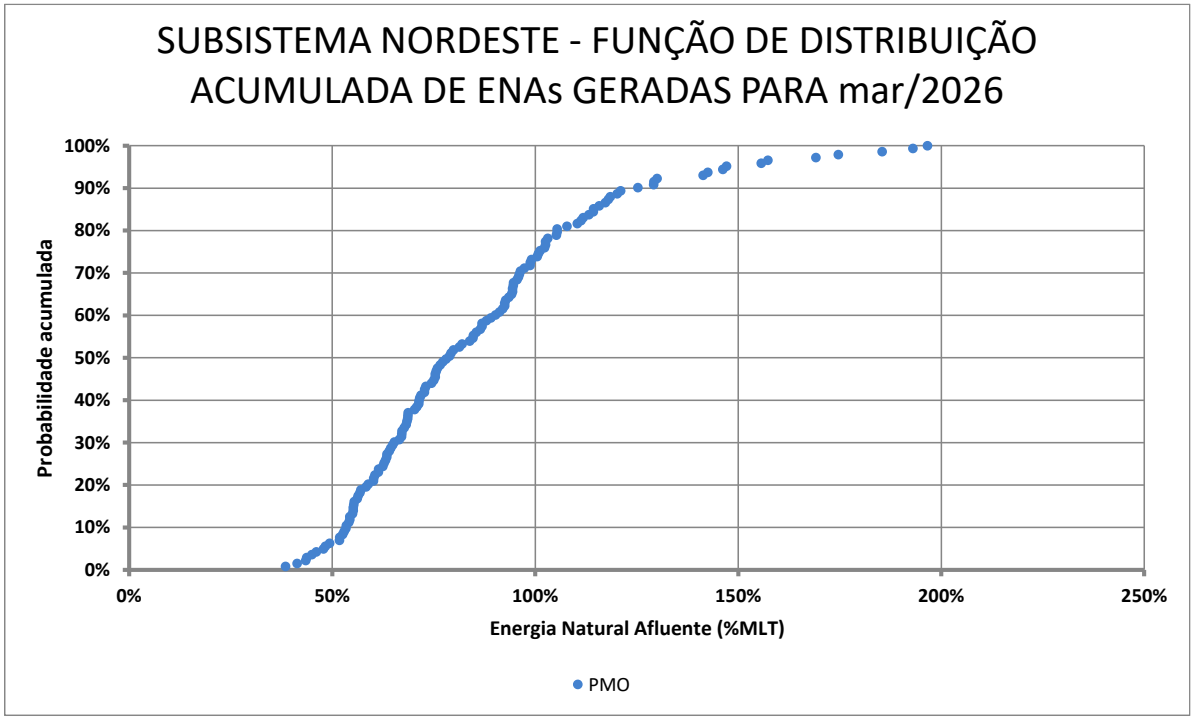

O conteúdo desta publicação foi produzido pelo ONS com base em dados e informações de conhecimento público. É de responsabilidade exclusiva dos agentes e demais interessados a obtenção de outros dados e informações, a realização de análises, estudos e avaliações para fins de tomada de decisões, definição de estratégias de atuação, assunção de compromissos e obrigações e quaisquer outras finalidades, em qualquer tempo e sob qualquer condição. É proibida a reprodução ou utilização total ou parcial do presente sem a identificação da fonte.

Figura 15 - Amplitude dos Cenários de ENA para o Subsistema Norte, em %MLT, para o PMO de Fevereiro/2026

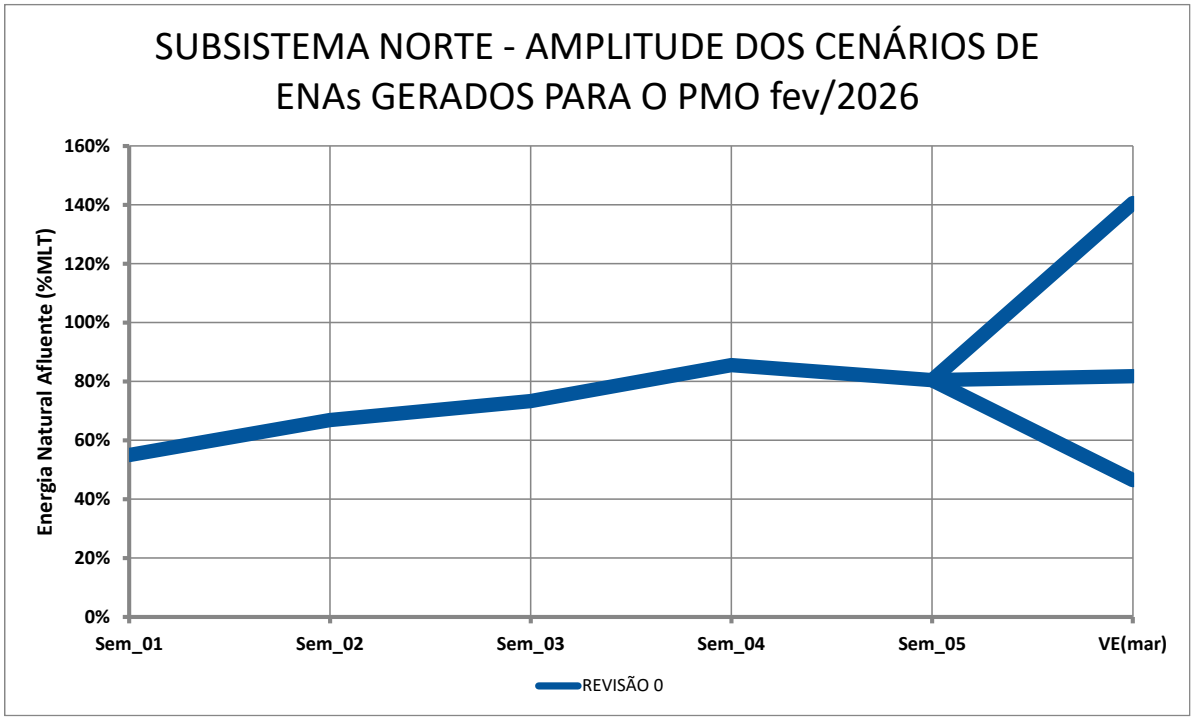

Figura 16 - Função de Distribuição Acumulada dos Cenários para o Subsistema Norte para o PMO de Fevereiro/2026

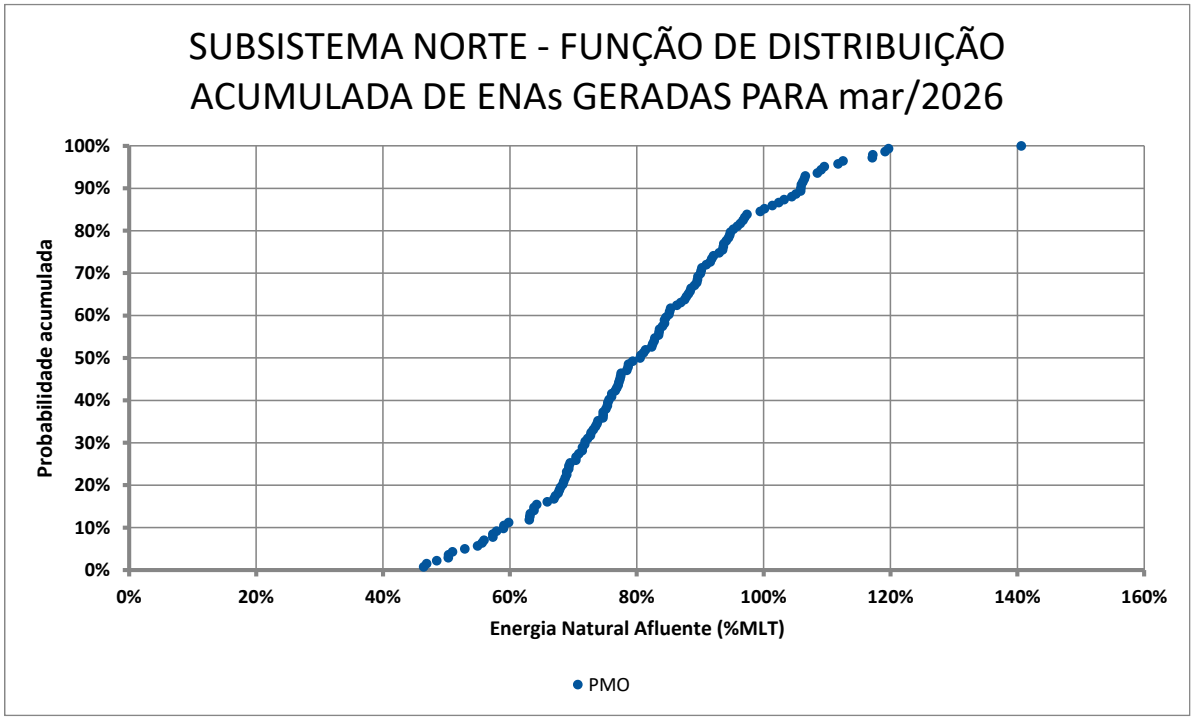

O conteúdo desta publicação foi produzido pelo ONS com base em dados e informações de conhecimento público. É de responsabilidade exclusiva dos agentes e demais interessados a obtenção de outros dados e informações, a realização de análises, estudos e avaliações para fins de tomada de decisões, definição de estratégias de atuação, assunção de compromissos e obrigações e quaisquer outras finalidades, em qualquer tempo e sob qualquer condição. É proibida a reprodução ou utilização total ou parcial do presente sem a identificação da fonte.

Os valores da MLT (Média de Longo Termo) das energias naturais afluentes para os meses de fevereiro/2026 e março/2026 são apresentados na tabela a seguir.

Tabela 3 – MLT da ENA nos meses de fevereiro/2026 e março/2026

MLT das ENAs (MWmed)		
Subsistema	fevereiro	março
SE/CO	70.844	69.061
S	8.249	7.105
NE	14.185	14.022
N	22.743	26.896

3.2. Limites de Intercâmbio entre Subsistemas

Os limites elétricos de intercâmbio de energia entre subsistemas são de fundamental importância para o processo de otimização energética, sendo determinantes para a definição das políticas de operação e do CMO para cada subsistema. Estes limites são influenciados por intervenções na malha de transmissão, notadamente na primeira semana operativa. O diagrama a seguir ilustra os fluxos notáveis do SIN e os limites aplicados neste PMO.

Figura 17 – Interligações entre regiões

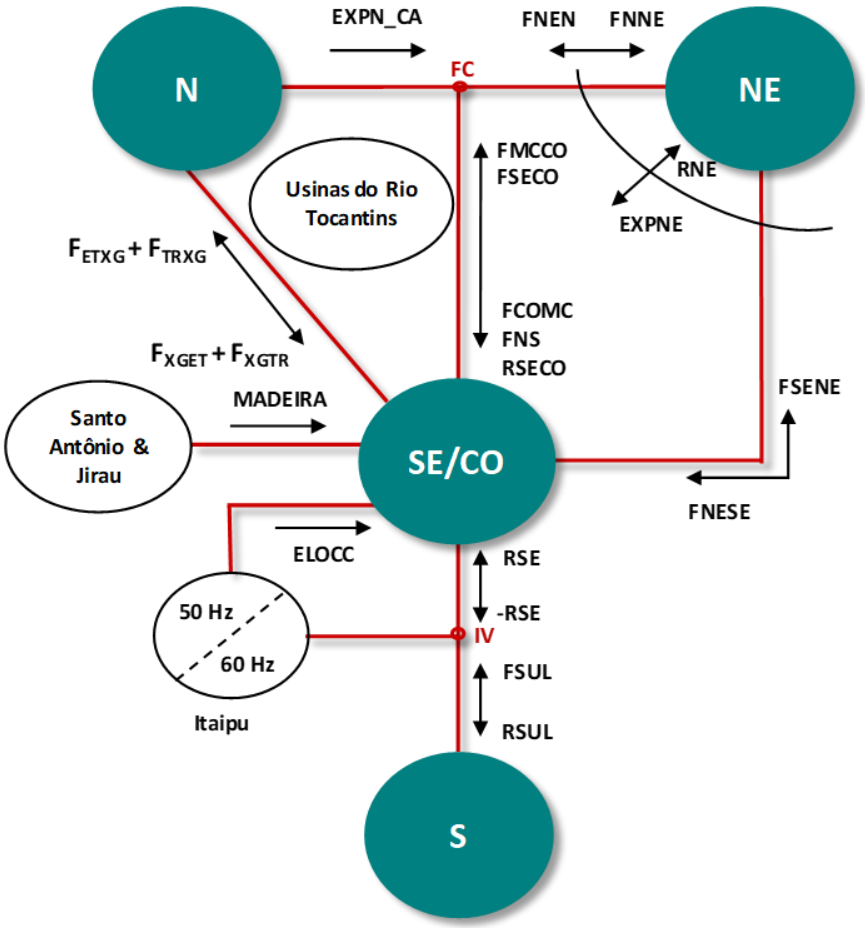

O conteúdo desta publicação foi produzido pelo ONS com base em dados e informações de conhecimento público. É de responsabilidade exclusiva dos agentes e demais interessados a obtenção de outros dados e informações, a realização de análises, estudos e avaliações para fins de tomada de decisões, definição de estratégias de atuação, assunção de compromissos e obrigações e quaisquer outras finalidades, em qualquer tempo e sob qualquer condição. É proibida a reprodução ou utilização total ou parcial do presente sem a identificação da fonte.

Tabela 4 – Limites considerados nesta semana operativa para intercâmbio de energia

Limites de Intercâmbio (MWmed)			
Fluxo	Patamar	31/01 a 06/02/2026	Demais Semanas
RNE	Pesada	11.000	11.000
	Média	11.000	11.000
	Leve	11.000	11.000
FNS	Pesada	3.200	3.200
	Média	3.200	3.200
	Leve	3.200	3.200
FNNE	Pesada	**4.500**	7.800
	Média	**5.214** (A)	7.800
	Leve	**6.408**	7.800
EXPORT. NE	Pesada	14.700	14.700
	Média	14.700	14.700
	Leve	14.700	14.700
FMCCO	Pesada	5.000	5.000
	Média	5.000	5.000
	Leve	5.000	5.000
FSENE	Pesada	6.000	6.000
	Média	6.000	6.000
	Leve	6.000	6.000
FNS + FNESE	Pesada	7.488	7.488
	Média	6.504	6.504
	Leve	7.700	7.700
RSE	Pesada	6.020	6.020
	Média	6.020	6.020
	Leve	7.730	7.730
FORNEC. SUL	Pesada	7.000	7.000
	Média	7.000	7.000
	Leve	7.000	7.000

Limites de Intercâmbio (MWmed)			
Fluxo	Patamar	31/01 a 06/02/2026	Demais Semanas
RECEB. SUL	Pesada	10.800	10.800
	Média	7.150	7.150
	Leve	9.800	9.800
ELO CC 50 Hz	Pesada	3.132	3.132
	Média	3.132	3.132
	Leve	3.132	3.132
ITAIPU 60 Hz	Pesada	7.200	7.200
	Média	7.200	7.200
	Leve	7.200	7.200
EXP. N CA	Pesada	8.000	8.000
	Média	8.000	8.000
	Leve	8.000	8.000
FETXG + FTRXG	Pesada	4.200	4.200
	Média	4.200	4.200
	Leve	4.200	4.200
FXGET + FXGTR	Pesada	8.000	8.000
	Média	8.000	8.000
	Leve	8.000	8.000
FNESE	Pesada	5.300	5.300
	Média	4.375	4.375
	Leve	5.300	5.300
FNEN	Pesada	**5.400**	6.800
	Média	**5.485** (A) (B)	6.800
	Leve	**5.167**	6.800
Ger_MADEIRA	Pesada	7.418	7.418
	Média	7.418	7.418
	Leve	7.418	7.418

(A) SGI 80.715-25
(B) SGI 2.543-26

O conteúdo desta publicação foi produzido pelo ONS com base em dados e informações de conhecimento público. É de responsabilidade exclusiva dos agentes e demais interessados a obtenção de outros dados e informações, a realização de análises, estudos e avaliações para fins de tomada de decisões, definição de estratégias de atuação, assunção de compromissos e obrigações e quaisquer outras finalidades, em qualquer tempo e sob qualquer condição. É proibida a reprodução ou utilização total ou parcial do presente sem a identificação da fonte.

3.3. Previsão de carga

Em janeiro de 2026, a confiança do empresário industrial, medida pelo ICEI da Confederação Nacional da Indústria (CNI), permaneceu em patamar de falta de confiança, apesar de leve melhora no início do ano. O índice avançou marginalmente em relação a dezembro, mas seguiu abaixo da linha de 50 pontos, indicando manutenção de um ambiente de cautela entre os empresários industriais. Segundo a CNI, o quadro permanece pessimista, sobretudo na avaliação do ambiente econômico, sugerindo que o setor ainda não apresenta tração consistente para uma retomada mais firme. Esse pano de fundo, juntamente com as festividades de fim de ano e as condições meteorológicas, contribui para contextualizar uma dinâmica de carga menos pressionada pela atividade produtiva no início do ano, sobretudo no Subsistema Sudeste/Centro-Oeste, onde a indústria tem maior peso relativo.

Com base no fechamento do PMO de Fevereiro, as projeções de carga indicam variações de -4,3% no Subsistema Sudeste/Centro-Oeste, -5,7% no Sul, 7,9% no Nordeste e 7,3% no Norte, em relação a fevereiro de 2025. A estimativa de fechamento da carga global na semana operativa atual (24/01 a 30/01) aponta, no Sistema Interligado Nacional (SIN), resultado 2,6% superior ao da semana anterior (17/01 a 23/01), refletindo principalmente as elevações observadas no Sul (11,8%) e no Sudeste/Centro-Oeste (1,6%). No Sul, o crescimento está associado ao patamar elevado de carga observado entre segunda-feira (26/01) e quinta-feira (29/01), em linha com o aumento das temperaturas máximas nas capitais da região. No Sudeste/Centro-Oeste, o avanço é explicado pela elevação das temperaturas máximas nas capitais do Rio de Janeiro, São Paulo e Belo Horizonte, refletindo diretamente na carga do subsistema. No Nordeste e no Norte, a carga apresentou baixa variação entre semanas (0,2% e -0,7%, respectivamente), em linha com a menor oscilação de temperatura e precipitação nas capitais dessas regiões.

Para a próxima semana operativa (31/01 a 06/02), projeta-se estabilidade relativa na carga do SIN (0,26%) em relação à semana atual, com expectativa de 86.250 MW médios. Esse comportamento está associado à manutenção das temperaturas em capitais de maior sensibilidade, como Rio de Janeiro, São Paulo e Belo Horizonte, além de Porto Alegre, Florianópolis e Curitiba. Por fim, para fevereiro, a sinalização é de temperaturas próximas às observadas em janeiro na maior parte das capitais, com expectativa de valores mais elevados em capitais do Sul.

Tabela 5 – Evolução da carga do PMO de Fevereiro de 2026

Subsistema	CARGA SEMANAL (MWmed)					CARGA MENSAL (MWmed)	
	1ª Sem	2ª Sem	3ª Sem	4ª Sem	5ª Sem	fev/26	Var. (%) fev/26 -> fev/25
SE/CO	47.285	49.588	48.588	50.003	50.348	48.975	-4,3%
Sul	16.220	15.970	15.569	15.766	15.311	15.849	-5,7%
Nordeste	14.467	14.695	14.221	14.635	14.632	14.510	7,9%
Norte	8.278	8.295	8.099	8.398	8.603	8.279	7,3%
SIN	**86.250**	**88.548**	**86.477**	**88.802**	**88.894**	**87.613**	**-1,7%**

O conteúdo desta publicação foi produzido pelo ONS com base em dados e informações de conhecimento público. É de responsabilidade exclusiva dos agentes e demais interessados a obtenção de outros dados e informações, a realização de análises, estudos e avaliações para fins de tomada de decisões, definição de estratégias de atuação, assunção de compromissos e obrigações e quaisquer outras finalidades, em qualquer tempo e sob qualquer condição. É proibida a reprodução ou utilização total ou parcial do presente sem a identificação da fonte.

3.4. Potência Hidráulica Total Disponível no SIN

O gráfico a seguir mostra a disponibilidade hidráulica total do SIN, para este mês, de acordo com o cronograma de manutenção informado pelos agentes para este PMO.

Figura 18 – Potência hidráulica disponível no SIN

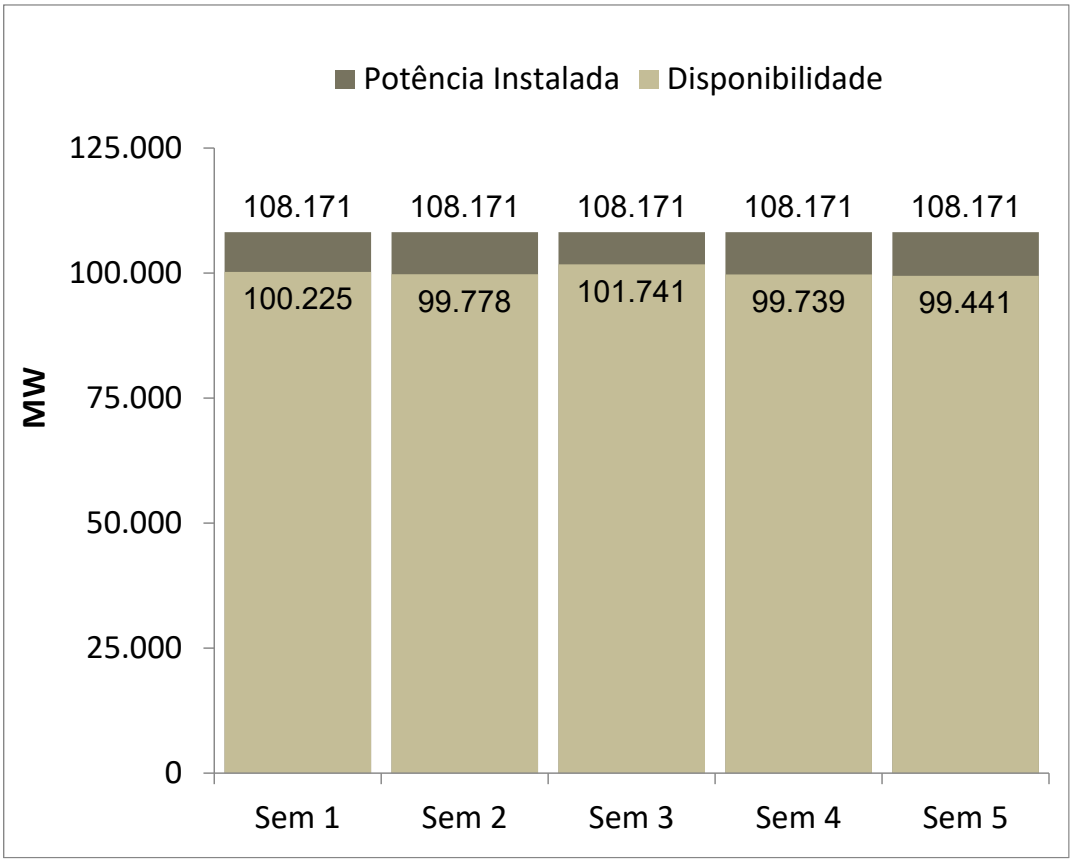

3.5. Armazenamentos Iniciais por Subsistema

Tabela 6 – Armazenamentos iniciais, por subsistema, considerados para esta semana operativa

Armazenamento (%EARmáx) - 0:00 h do dia 31/01/2026		
Subsistema	**Nível previsto na Revisão 4 do PMO Jan/2026**	**Partida informada pelos Agentes para a Revisão 0 do PMO Fev/2026**
SE/CO	46,1	46,5
S	64,0	60,1
NE	53,0	52,9
N	58,6	59,1

A primeira coluna da tabela acima corresponde ao armazenamento previsto na Revisão 4 do PMO de Janeiro de 2026, para a 0:00 h do dia 31/01/2026. A segunda coluna apresenta os armazenamentos obtidos a partir dos níveis de partida informados pelos Agentes de Geração para seus aproveitamentos com reservatórios.

O conteúdo desta publicação foi produzido pelo ONS com base em dados e informações de conhecimento público. É de responsabilidade exclusiva dos agentes e demais interessados a obtenção de outros dados e informações, a realização de análises, estudos e avaliações para fins de tomada de decisões, definição de estratégias de atuação, assunção de compromissos e obrigações e quaisquer outras finalidades, em qualquer tempo e sob qualquer condição. É proibida a reprodução ou utilização total ou parcial do presente sem a identificação da fonte.

4. PRINCIPAIS RESULTADOS

4.1. Política de Operação Energética

Para esta semana operativa, está prevista a seguinte política de intercâmbio de energia entre regiões:

Região SE/CO:

- Geração dimensionada para controle de nível em função das condições hidrológicas. Atendimento nos períodos de carga pesada.

Região Sul:

- Geração hidráulica em atendimento à Res. ANA 2.081/2017 minimizada para alocação de geração de mais fontes do NE e aumento de geração do Norte.

Região NE:

- Exploração dos recursos em função das disponibilidades energéticas e priorizando os períodos de carga pesada.

Região Norte:

- Exploração dos recursos em função das disponibilidades energéticas e priorizando os períodos de carga pesada.

4.2. Custo Marginal de Operação – CMO

A figura a seguir apresenta os Custos Marginais de Operação, em valores médios semanais, para as semanas operativas deste mês.

Figura 19 – CMO em valores médios

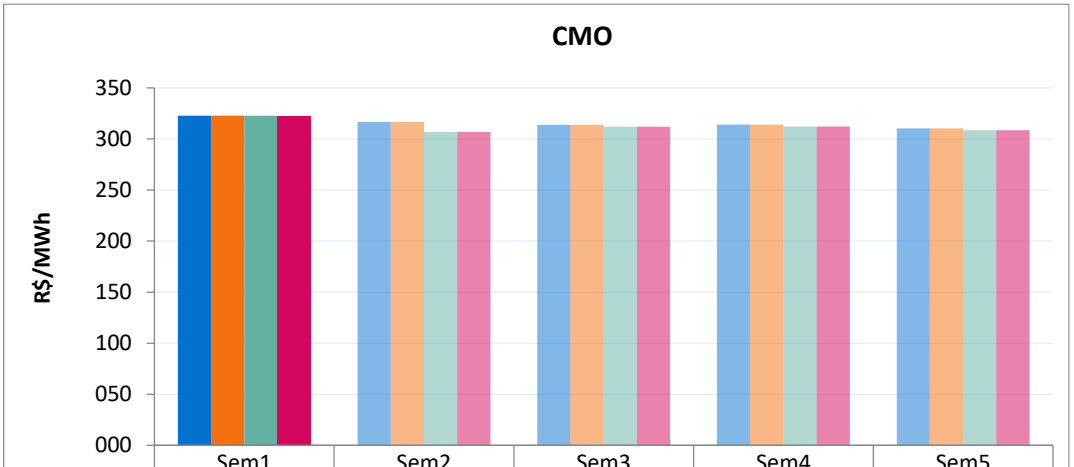

	Sem1	Sem2	Sem3	Sem4	Sem5
Sudeste	322,62	316,59	313,73	313,94	310,41
Sul	322,62	316,59	313,73	313,94	310,41
Nordeste	322,62	306,95	311,87	312,14	308,55
Norte	322,62	306,95	311,87	312,14	308,55

O conteúdo desta publicação foi produzido pelo ONS com base em dados e informações de conhecimento público. É de responsabilidade exclusiva dos agentes e demais interessados a obtenção de outros dados e informações, a realização de análises, estudos e avaliações para fins de tomada de decisões, definição de estratégias de atuação, assunção de compromissos e obrigações e quaisquer outras finalidades, em qualquer tempo e sob qualquer condição. É proibida a reprodução ou utilização total ou parcial do presente sem a identificação da fonte.

A tabela a seguir apresenta o custo marginal de operação, por subsistema e patamar de carga, para a próxima semana operativa.

Tabela 7 – CMO para esta semana operativa

Patamares de Carga	CMO (R$/MWh)			
	SE/CO	S	NE	N
Pesada	326,50	326,50	326,50	326,50
Média	323,89	323,89	323,89	323,89
Leve	319,34	319,34	319,34	319,34
Média Semanal	322,62	322,62	322,62	322,62

4.3. Energia Armazenada

O processo de otimização realizado pelo programa DECOMP indicou os armazenamentos mostrados na figura a seguir para as próximas semanas operativas do mês de fevereiro/2026.

Figura 20 – Energias Armazenadas nas semanas operativas do mês de fevereiro/2026

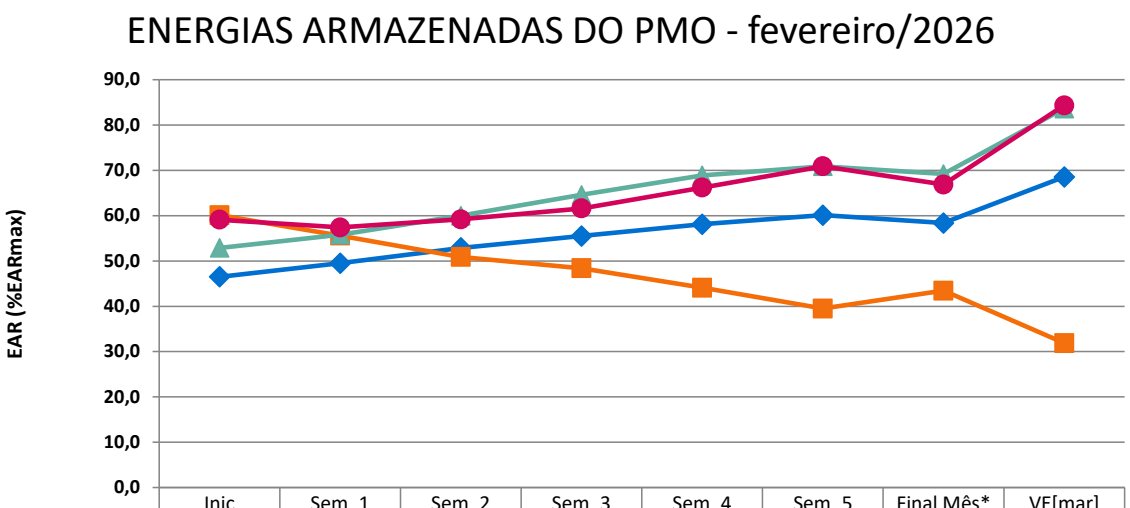

	Inic	Sem_1	Sem_2	Sem_3	Sem_4	Sem_5	Final Mês*	VE[mar]
SE/CO	46,5	49,5	52,9	55,5	58,1	60,1	58,4	68,5
SUL	60,1	55,6	50,9	48,4	44,1	39,5	43,4	31,9
NORDESTE	52,9	55,8	60,0	64,6	68,9	70,9	69,2	83,6
NORTE	59,1	57,4	59,2	61,6	66,2	70,9	66,9	84,3

Os armazenamentos da figura anterior estão expressos em percentual da Energia Armazenável Máxima de cada subsistema, que são mostradas na tabela a seguir.

Tabela 8 – Energia Armazenável Máxima por subsistema no PMO de fevereiro/2026

ENERGIA ARMAZENÁVEL MÁXIMA (MWmed)		
Subsistema	fevereiro	março
SE/CO	205.569	205.569
S	20.458	20.458
NE	51.718	51.718
N	15.144	14.860

O conteúdo desta publicação foi produzido pelo ONS com base em dados e informações de conhecimento público. É de responsabilidade exclusiva dos agentes e demais interessados a obtenção de outros dados e informações, a realização de análises, estudos e avaliações para fins de tomada de decisões, definição de estratégias de atuação, assunção de compromissos e obrigações e quaisquer outras finalidades, em qualquer tempo e sob qualquer condição. É proibida a reprodução ou utilização total ou parcial do presente sem a identificação da fonte.

5. GERAÇÃO TÉRMICA

A Figura 21 apresenta, para cada subsistema do SIN, o despacho térmico por modalidade indicado pelo Decomp para esta semana operativa.

Figura 21 – Geração térmica para a próxima semana operativa

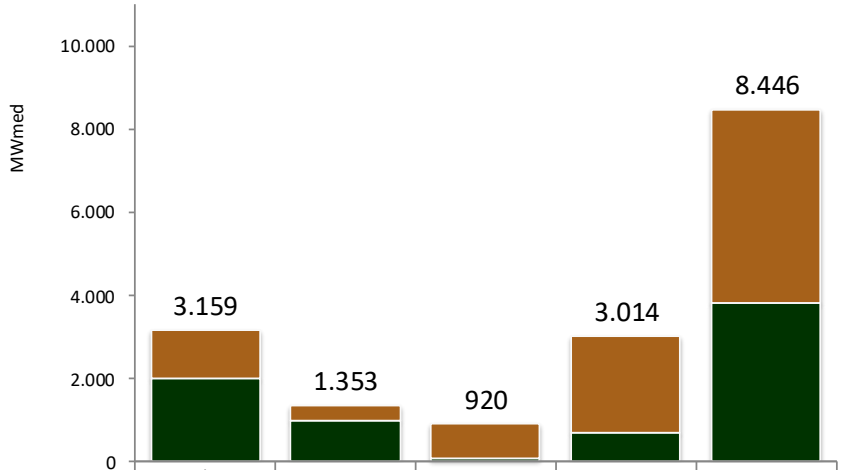

	SE/CO	SUL	NE	NORTE	SIN
TOTAL	3.159	1.353	920	3.014	8.446
ORDEM DE MÉRITO	1150	353	825	2306	4634
RESTRIÇÃO ELÉTRICA	0	0	0	0	0
INFLEXIBILIDADE	2009	1000	95	708	3812

O gráfico a seguir apresenta a expectativa de despacho térmico para os dois meses do horizonte de estudo.

Figura 22 – Expectativa de despacho térmico para o horizonte de dois meses

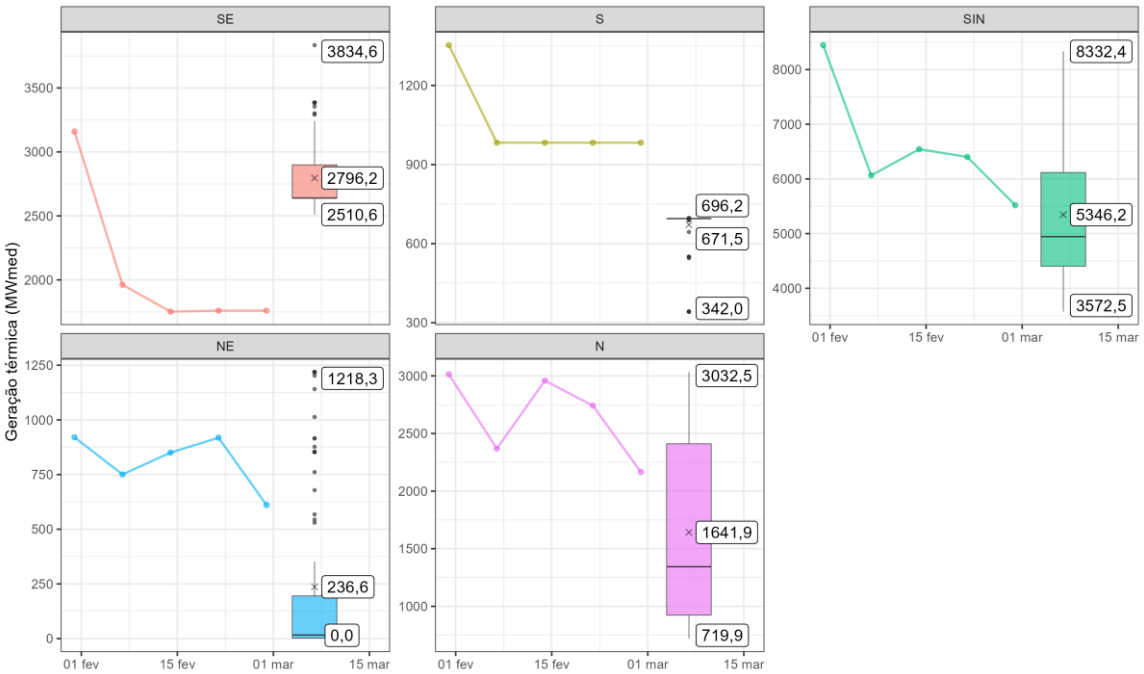

O conteúdo desta publicação foi produzido pelo ONS com base em dados e informações de conhecimento público. É de responsabilidade exclusiva dos agentes e demais interessados a obtenção de outros dados e informações, a realização de análises, estudos e avaliações para fins de tomada de decisões, definição de estratégias de atuação, assunção de compromissos e obrigações e quaisquer outras finalidades, em qualquer tempo e sob qualquer condição. É proibida a reprodução ou utilização total ou parcial do presente sem a identificação da fonte.

Na tabela abaixo segue a Indicação de despacho antecipado por ordem de mérito de custo para a semana de 04/04/2026 a 10/04/2026.

Tabela 9 – UTEs com contrato de combustível GNL

UTE			Benefício (R$/MWh)			Despacho antecipado por mérito		
Nome	Código	CVU (R$/MWh)	Carga Pesada	Carga Média	Carga Leve	Carga Pesada	Carga Média	Carga Leve
SANTA CRUZ	86	319,46	174,07	166,63	149,21	Não	Não	Não
PSERGIPE I	224	300,35	174,01	156,51	148,02	Não	Não	Não

Assim sendo, não há previsão de despacho antecipado por ordem de mérito de custo para as UTE Santa Cruz e Porto Sergipe I, para a semana de 04/04/2026 a 10/04/2026.

6. RESUMO DOS RESULTADOS DO PMO

As figuras a seguir apresentam um resumo dos resultados do PMO de Fevereiro/2026, com informações da Energia Natural Afluente (ENA), da Energia Armazenada (EAR) e do Custo Marginal de Operação (CMO) nos subsistemas do Sistema Interligado Nacional (SIN). São apresentados os valores semanais observados e previstos e o valor esperado dos cenários gerados para o mês de março/2026.

Figura 23 – Resumo de fevereiro/2026 para o Subsistema Sudeste/Centro-Oeste

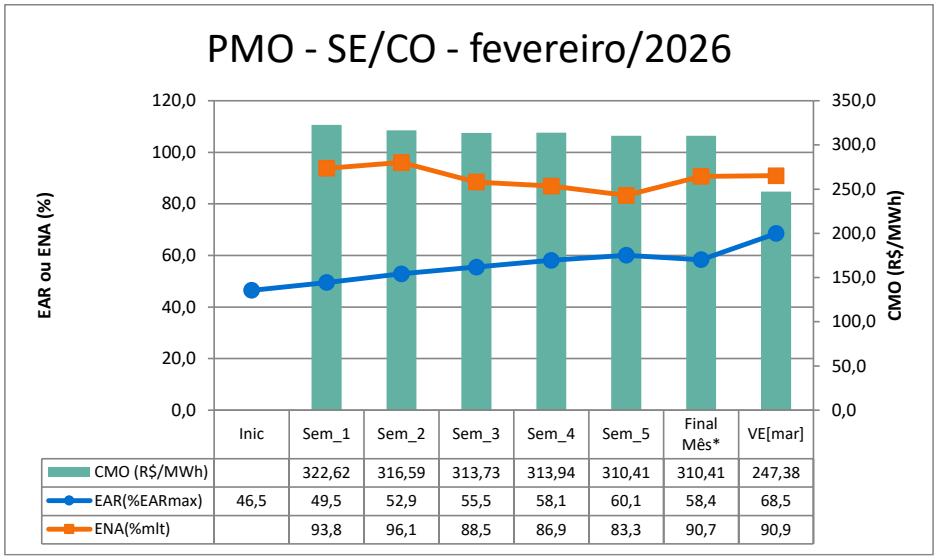

O conteúdo desta publicação foi produzido pelo ONS com base em dados e informações de conhecimento público. É de responsabilidade exclusiva dos agentes e demais interessados a obtenção de outros dados e informações, a realização de análises, estudos e avaliações para fins de tomada de decisões, definição de estratégias de atuação, assunção de compromissos e obrigações e quaisquer outras finalidades, em qualquer tempo e sob qualquer condição. É proibida a reprodução ou utilização total ou parcial do presente sem a identificação da fonte.

Figura 24 – Resumo de fevereiro/2026 para o Subsistema Sul

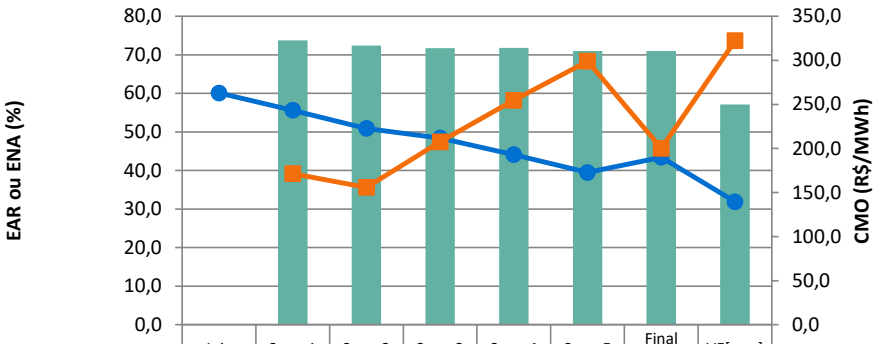

	Inic	Sem_1	Sem_2	Sem_3	Sem_4	Sem_5	Final Mês*	VE[mar]
CMO (R$/MWh)		322,62	316,59	313,73	313,94	310,41	310,41	249,95
EAR(%EARmax)	60,1	55,6	50,9	48,4	44,1	39,5	43,4	31,9
ENA(%mlt)		39,2	35,6	47,4	58,2	68,3	45,8	73,6

Figura 25 – Resumo de fevereiro/2026 para o Subsistema Nordeste

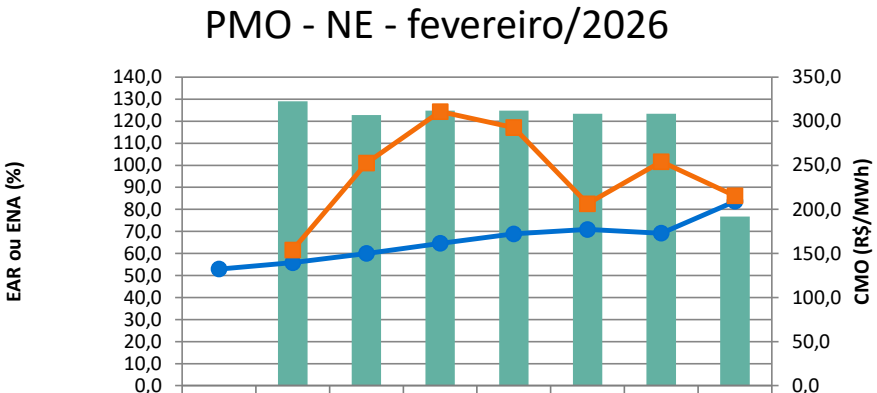

	Inic	Sem_1	Sem_2	Sem_3	Sem_4	Sem_5	Final Mês*	VE[mar]
CMO (R$/MWh)		322,62	306,95	311,87	312,14	308,55	308,55	191,79
EAR(%EARmax)	52,9	55,8	60,0	64,6	68,9	70,9	69,2	83,6
ENA(%mlt)		61,6	101,0	124,4	117,1	82,5	101,6	86,1

Figura 26 – Resumo de fevereiro/2026 para o Subsistema Norte

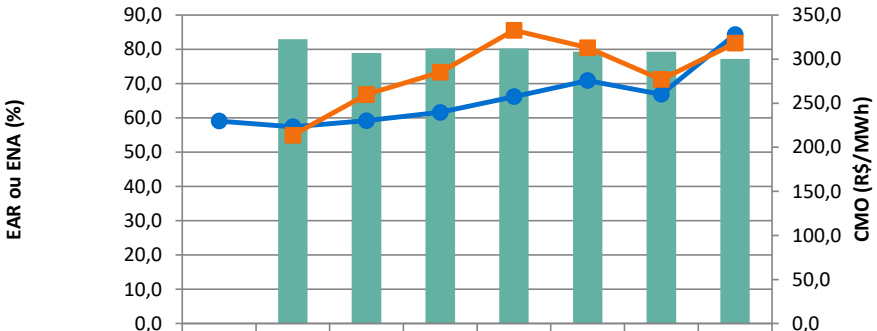

	Inic	Sem_1	Sem_2	Sem_3	Sem_4	Sem_5	Final Mês*	VE[mar]
CMO (R$/MWh)		322,62	306,95	311,87	312,14	308,55	308,55	300,11
EAR(%EARmax)	59,1	57,4	59,2	61,6	66,2	70,9	66,9	84,3
ENA(%mlt)		55,0	66,8	73,3	85,6	80,5	71,2	81,8

O conteúdo desta publicação foi produzido pelo ONS com base em dados e informações de conhecimento público. É de responsabilidade exclusiva dos agentes e demais interessados a obtenção de outros dados e informações, a realização de análises, estudos e avaliações para fins de tomada de decisões, definição de estratégias de atuação, assunção de compromissos e obrigações e quaisquer outras finalidades, em qualquer tempo e sob qualquer condição. É proibida a reprodução ou utilização total ou parcial do presente sem a identificação da fonte.

7. ARMAZENAMENTOS OPERATIVOS

Para uma melhor avaliação de diversos cenários hidrometeorológicos, notadamente, aqueles de curto prazo e suas influências nas previsões de vazões nos subsistemas, os resultados deste PMO contemplam cenários de afluências visando melhor representar a ocorrência de precipitação e, consequentemente, seus efeitos sobre as afluências e armazenamentos.

Apresentamos a seguir as correspondentes energias naturais afluentes e os resultados obtidos com a aplicação do cenário de afluência utilizado no estudo.

Tabela 10 – Previsão de ENA do caso de valor esperado das previsões de afluência

Subsistema	ENERGIAS NATURAIS AFLUENTES			
	Previsão Semanal		Previsão Mensal	
	(MWmed)	%MLT	(MWmed)	%MLT
SE/CO	65.790	94	64.239	91
Sul	3.195	39	3.775	46
Nordeste	8.663	62	14.415	102
Norte	12.209	56	16.190	71

Tabela 11 – Previsão de %EARmáx para o final do mês

Subsistema	% EARmáx 30/01	% EARmáx - 28/02
	NÍVEL INICIAL	NÍVEL PMO
SE/CO	46,5	58,4
Sul	60,1	43,4
Nordeste	52,9	69,2
Norte	59,1	66,9

O conteúdo desta publicação foi produzido pelo ONS com base em dados e informações de conhecimento público. É de responsabilidade exclusiva dos agentes e demais interessados a obtenção de outros dados e informações, a realização de análises, estudos e avaliações para fins de tomada de decisões, definição de estratégias de atuação, assunção de compromissos e obrigações e quaisquer outras finalidades, em qualquer tempo e sob qualquer condição. É proibida a reprodução ou utilização total ou parcial do presente sem a identificação da fonte.

8. RESERVATÓRIOS EQUIVALENTES DE ENERGIA

A seguir são apresentadas as previsões de Energia Natural Afluente para a próxima semana operativa e para o mês de fevereiro, bem como as previsões de Energia Armazenada nos Reservatórios Equivalentes de Energia – REE, do PMO de Fevereiro de 2026.

Tabela 12 – Previsão de ENA por REE

Valor Esperado das Energias Naturais Afluentes				
REE	Previsão Semanal		Previsão Mensal	
	31/01/2026 a 06/02/2026		fev/26	
	(MWmed)	%MLT	(MWmed)	%MLT
Sudeste	8.823	83	8.416	80
Madeira	11.303	111	11.573	110
Teles Pires	3.465	88	4.076	101
Itaipu	3.431	88	3.730	94
Paraná	36.096	96	33.459	88
Paranapanema	2.663	71	2.977	79
Sul	1.597	42	1.900	49
Iguaçu	1.598	37	1.876	43
Nordeste	8.663	62	14.415	102
Norte	6.284	51	8.972	70
Belo Monte	5.075	59	6.425	70
Manaus	594	74	753	88

Tabela 13 – Previsão de %EARmáx por REE

% Energia Armazenável Máxima		
REE	Previsão Semanal	Previsão Mensal
	06-fev	28-fev
	(%EARmáx)	(%EARmáx)
Sudeste	54,9	59,0
Madeira	68,2	76,8
Teles Pires	24,2	51,4
Itaipu	52,9	96,1
Paraná	46,9	58,3
Paranapanema	59,0	55,2
Sul	64,8	48,8
Iguaçu	46,5	38,3
Nordeste	55,8	69,2
Norte	58,3	68,6
Belo Monte	8,6	26,0
Manaus	43,9	37,2

O conteúdo desta publicação foi produzido pelo ONS com base em dados e informações de conhecimento público. É de responsabilidade exclusiva dos agentes e demais interessados a obtenção de outros dados e informações, a realização de análises, estudos e avaliações para fins de tomada de decisões, definição de estratégias de atuação, assunção de compromissos e obrigações e quaisquer outras finalidades, em qualquer tempo e sob qualquer condição. É proibida a reprodução ou utilização total ou parcial do presente sem a identificação da fonte.

9. DESPACHO TÉRMICO POR MODALIDADE, PATAMAR DE CARGA E USINA

Nas tabelas abaixo, a diferenciação entre geração por inflexibilidade e por ordem de mérito tem caráter informativo, com o objetivo de detalhar a informação de inflexibilidade enviada pelos respectivos agentes para o PMO. Ressalta-se que nas etapas de Programação Diária e Tempo Real, o montante despachado nas usinas termelétricas indicadas por ordem de mérito é plenamente intitulado como ordem de mérito.

REGIÃO SUDESTE/CENTRO-OESTE

Térmicas Potência (MW)	Combustível	CVU (R$/MWh)	Inflexibilidade			Ordem de Mérito			Total Mérito e INFL.			Razão Elétrica			Total UTE		
			P	M	L	P	M	L	P	M	L	P	M	L	P	M	L
ATLAN_CSA (255)	Resíduos	0,00	161,4	161,4	161,4				161,4	161,4	161,4				161,4	161,4	161,4
ATLANTICO (235)	Resíduos	0,00	160,8	160,8	160,8				160,8	160,8	160,8				160,8	160,8	160,8
DAIA (44)	Diesel	0,00															
PALMEIR_GO (176)	Diesel	0,00															
PAULINIA (16)	Gás	0,00															
TNORTE 2 (349)	Óleo	0,00															
W.ARJONA O (177)	Diesel	0,00															
XAVANTES (54)	Diesel	0,00															
ANGRA 2 (1350)	Nuclear	20,12				0,0	0,0	0,0									
ANGRA 1 (640)	Nuclear	31,17	640,0	640,0	640,0	0,0	0,0	0,0	640,0	640,0	640,0				640,0	640,0	640,0
M.AZUL (566)	Gás	128,17	495,0	495,0	495,0	70,5	70,5	70,5	565,5	565,5	565,5				565,5	565,5	565,5
O.PINTADA (50)	Biomassa	152,33				50,0	50,0	50,0	50,0	50,0	50,0				50,0	50,0	50,0
UTE STA VI (41)	Biomassa	164,56				0,0	0,0	0,0									
ST.CRUZ 34 (436)	Óleo	310,41				0,0	0,0	0,0									
BAIXADA FL (530)	Gás	314,89				530,0	530,0	530,0	530,0	530,0	530,0				530,0	530,0	530,0
SANTA CRUZ (500)	GNL	319,46				500,0	500,0	500,0	500,0	500,0	500,0				500,0	500,0	500,0
CUBATAO (216)	Gás	342,53	82,0	78,5	81,0				82,0	78,5	81,0				82,0	78,5	81,0
UTE GNA II (1673)	Gás	445,95															
UTE GNA I (1338)	Gás	617,01															
KARKEY 013 (259)	Gás	703,10	31,0	31,0	31,0				31,0	31,0	31,0				31,0	31,0	31,0
KARKEY 019 (116)	Gás	703,10															
T.LAGOAS (350)	Gás	766,64															
CUIABA CC (529)	Gás	825,02															
PORSUD I (116)	Gás	834,61															
PORSUD II (78)	Gás	836,73															
W.ARJONA (177)	Gás	841,11															
IBIRITE (226)	Gás	841,37															
TERMORIO (989)	Gás	842,32	290,0	290,0	290,0				290,0	290,0	290,0				290,0	290,0	290,0
LUIZORMELO (204)	Gás	914,11															
NORTEFLU (826)	Gás	953,55															
POVOACAO I (75)	Gás	958,82															
VIANA (175)	Óleo	975,44															
T.MACAE (922)	Gás	1011,95	425,3	68,6	117,4				425,3	68,6	117,4				425,3	68,6	117,4
SEROPEDICA (360)	Gás	1068,51															
J.FORA (87)	Gás	1078,63															
VIANA I (37)	Gás	1096,46															
NPIRATINGA (572)	Gás	1294,25															
TOTAL SE/CO (14744)			2285,5	1925,3	1976,6	1150,5	1150,5	1150,5	3436,0	3075,8	3127,1	0,0	0,0	0,0	3436,0	3075,8	3127,1

REGIÃO SUL

Térmicas Potência (MW)	Combustível	CVU (R$/MWh)	Inflexibilidade			Ordem de Mérito			Total Mérito e INFL.			Razão Elétrica			Total UTE		
			P	M	L	P	M	L	P	M	L	P	M	L	P	M	L
B.BONITA I (10)	Gás	0,00															
URUGUAIANA (640)	Gás	0,00															
PAMPA SUL (345)	Carvão	105,94				345,0	345,0	345,0	345,0	345,0	345,0				345,0	345,0	345,0
SAO SEPE (8)	Biomassa	118,84				8,0	8,0	8,0	8,0	8,0	8,0				8,0	8,0	8,0
J.LACER. C (330)	Carvão	347,20	300,0	300,0	300,0				300,0	300,0	300,0				300,0	300,0	300,0
J.LACER. B (220)	Carvão	406,71	220,0	220,0	220,0				220,0	220,0	220,0				220,0	220,0	220,0
J.LAC. A2 (110)	Carvão	416,40	110,0	110,0	110,0				110,0	110,0	110,0				110,0	110,0	110,0
J.LAC. A1 (80)	Carvão	518,92	40,0	40,0	40,0				40,0	40,0	40,0				40,0	40,0	40,0
CANDIOTA_3 (350)	Carvão	519,71	330,0	330,0	330,0				330,0	330,0	330,0				330,0	330,0	330,0
ARAUCARIA (484)	Gás	969,68															
CANOAS (249)	Gás	1375,20															
TOTAL SUL (2826)			1000,0	1000,0	1000,0	353,0	353,0	353,0	1353,0	1353,0	1353,0	0,0	0,0	0,0	1353,0	1353,0	1353,0

O conteúdo desta publicação foi produzido pelo ONS com base em dados e informações de conhecimento público. É de responsabilidade exclusiva dos agentes e demais interessados a obtenção de outros dados e informações, a realização de análises, estudos e avaliações para fins de tomada de decisões, definição de estratégias de atuação, assunção de compromissos e obrigações e quaisquer outras finalidades, em qualquer tempo e sob qualquer condição. É proibida a reprodução ou utilização total ou parcial do presente sem a identificação da fonte.

REGIÃO NORDESTE

Térmicas Potência (MW)	Combustível	CVU (R$/MWh)	Inflexibilidade			Ordem de Mérito			Total Mérito e INFL.			Razão Elétrica			Total UTE		
			P	M	L	P	M	L	P	M	L	P	M	L	P	M	L
MARACANAU (168)	Óleo	0,00															
PETROLINA (136)	Óleo	0,00															
ERB CANDEI (17)	Biomassa	118,93				12,0	12,0	12,0	12,0	12,0	12,0				12,0	12,0	12,0
PROSP_I (28)	Gás	224,31				18,7	18,7	18,7	18,7	18,7	18,7				18,7	18,7	18,7
PROSP_III (56)	Gás	228,55				46,7	46,7	46,7	46,7	46,7	46,7				46,7	46,7	46,7
PROSP_II (37)	Gás	271,14				28,0	28,0	28,0	28,0	28,0	28,0				28,0	28,0	28,0
PSERGIPE I (1593)	GNL	300,35				0,0	0,0	0,0									
P.PECEM1 (720)	Carvão	306,64				720,0	720,0	720,0	720,0	720,0	720,0				720,0	720,0	720,0
P.PECEM2 (365)	Carvão	317,47				0,0	0,0	0,0									
VALE ACU (110)	Gás	450,86															
PERNAMBU_3 (201)	Óleo	741,18															
TERMOPE (550)	Gás	806,73															
SUAPE II (381)	Óleo	875,88															
T.BAHIA (186)	Gás	984,89	95,0	95,0	95,0				95,0	95,0	95,0				95,0	95,0	95,0
GLOBAL I (136)	Óleo	1104,92															
GLOBAL II (136)	Óleo	1104,92															
TERMOCABO (50)	Óleo	1504,27															
POTIGUAR (53)	Diesel	1838,20															
POTIGUAR_3 (66)	Diesel	1838,20															
TERMONE (171)	Óleo	1840,95															
TERMOPB (171)	Óleo	1840,95															
CAMPINA_GR (169)	Óleo	2085,48															
TERMOCEARA (223)	Óleo	2237,72															
C.MURICY 2 (144)	Óleo	2295,76															
PECEM 2 (144)	Óleo	2319,64															
TOTAL NE (5725)			95,0	95,0	95,0	825,4	825,4	825,4	920,4	920,4	920,4	0,0	0,0	0,0	920,4	920,4	920,4

REGIÃO NORTE

Térmicas Potência (MW)	Combustível	CVU (R$/MWh)	Inflexibilidade			Ordem de Mérito			Total Mérito e INFL.			Razão Elétrica			Total UTE		
			P	M	L	P	M	L	P	M	L	P	M	L	P	M	L
MARANHAO3 (519)	Gás	116,10		48,0	132,0	499,6	457,5	379,6	499,6	505,5	511,6				499,6	505,5	511,6
APARECIDA (166)	Gás	149,00	90,0	90,0	90,0	27,0	27,0	27,0	117,0	117,0	117,0				117,0	117,0	117,0
JARAQUI (75)	Gás	149,00	49,3	46,0	40,1	13,7	17,0	22,9	63,0	63,0	63,0				63,0	63,0	63,0
PIRARUCU (73)	Gás	149,00	66,0	61,3	52,9	1,0	5,7	14,2	67,0	67,0	67,0				67,0	67,0	67,0
PORAQUE (85)	Gás	149,00	49,5	46,4	40,7	18,5	21,6	27,3	68,0	68,0	68,0				68,0	68,0	68,0
TAMBAQUI (93)	Gás	149,00	48,3	50,1	52,1	14,7	12,9	10,9	63,0	63,0	63,0				63,0	63,0	63,0
TUCUNARE (73)	Gás	149,00	66,0	61,3	52,9	0,0	4,7	13,2	66,0	66,0	66,0				66,0	66,0	66,0
UTE MAUA 3 (591)	Gás	149,00	264,0	264,0	264,0	326,8	326,8	326,8	590,8	590,8	590,8				590,8	590,8	590,8
PARNAIBA_V (386)	Vapor	231,22				0,0	22,6	63,5		22,6	63,5				0,0	22,6	63,5
JAGUATI II (141)	Gás	289,25				126,2	126,2	126,2	126,2	126,2	126,2				126,2	126,2	126,2
MARANHAO V (338)	Gás	293,89				329,2	331,8	334,4	329,2	331,8	334,4				329,2	331,8	334,4
MARANHAOIV (338)	Gás	293,89				329,2	331,8	334,4	329,2	331,8	334,4				329,2	331,8	334,4
N.VENECIA2 (270)	Gás	308,35				259,9	261,6	263,3	259,9	261,6	263,3				259,9	261,6	263,3
P. ITAQUI (360)	Carvão	309,35				360,1	360,1	360,1	360,1	360,1	360,1				360,1	360,1	360,1
BONFIM (12)	Biomassa	555,69	5,0	5,0	5,0				5,0	5,0	5,0				5,0	5,0	5,0
CANTA (12)	Biomassa	555,69	5,0	5,0	5,0				5,0	5,0	5,0				5,0	5,0	5,0
PAU RAINHA (12)	Biomassa	555,69	5,0	5,0	5,0				5,0	5,0	5,0				5,0	5,0	5,0
SANTA LUZ (12)	Biomassa	555,69	5,0	5,0	5,0				5,0	5,0	5,0				5,0	5,0	5,0
PARNAIB_IV (56)	Gás	759,24															
BBF BALIZA (18)	Biomassa	876,44	5,0	5,0	5,0				5,0	5,0	5,0				5,0	5,0	5,0
GERAMAR1 (166)	Óleo	900,08															
GERAMAR2 (166)	Óleo	900,08															
M.C.SUCUBA (42)	Diesel	1738,08															
PALMAPLAN (12)	Biomassa	1864,46															
TOTAL NORTE (4303)			658,1	692,1	749,6	2305,9	2307,3	2303,7	2964,0	2999,4	3053,3	0,0	0,0	0,0	2964,0	2999,4	3053,3

O conteúdo desta publicação foi produzido pelo ONS com base em dados e informações de conhecimento público. É de responsabilidade exclusiva dos agentes e demais interessados a obtenção de outros dados e informações, a realização de análises, estudos e avaliações para fins de tomada de decisões, definição de estratégias de atuação, assunção de compromissos e obrigações e quaisquer outras finalidades, em qualquer tempo e sob qualquer condição. É proibida a reprodução ou utilização total ou parcial do presente sem a identificação da fonte.