1. APRESENTAÇÃO

Na semana de 08/02 a 14/02, houve precipitação nas bacias das regiões Centro-Oeste e Norte, com os maiores totais observados nas bacias dos rios Madeira, Tocantins, Xingu e Tapajós.

Na semana de 15/02 a 21/02, deve ocorrer precipitação nas regiões Centro-Oeste e Norte, com maiores totais de precipitação nas bacias dos rios Jacuí, Uruguai, Madeira, Tapajós e Xingu.

Os valores médios semanais do Custo Marginal de Operação – CMO dos subsistemas do SIN sofreram as seguintes alterações em relação à semana anterior:

- SE/CO: de R$ 102,34/MWh para R$ 124,80/MWh
- Sul: de R$ 102,34/MWh para R$ 124,80/MWh
- Nordeste: manteve-se em R$ 0,00/MWh
- Norte: manteve-se em R$ 0,00/MWh

Desde o dia 01/01/2020, o despacho por ordem de mérito é indicado diariamente pelos resultados do modelo DESSEM. Assim, o despacho por ordem de mérito semanal, conforme publicado nesse documento, tem caráter apenas informativo. Da mesma forma, desde o dia 01/01/2021, a formação de preço deixou o formato semanal/patamar de carga e passou a ser horário, de acordo também com os resultados do modelo DESSEM.

2. NOTÍCIAS

Nos dias 27 e 28 de fevereiro será realizada a reunião de elaboração do PMO de Março de 2025, com transmissão ao vivo através do site do ONS.

3. INFORMAÇÕES CONJUNTURAIS PARA ELABORAÇÃO DO PMO

3.1. Informações Hidrometeorológicas

3.1.1. Condições antecedentes

A atuação de áreas de instabilidade nas Regiões Centro-Oeste e Norte ocasionou precipitação nas bacias hidrográficas dessas regiões, com os maiores totais observados nas bacias dos rios Madeira, Tocantins, Xingu e Tapajós (Figura 1).

O conteúdo desta publicação foi produzido pelo ONS com base em dados e informações de conhecimento público. É de responsabilidade exclusiva dos agentes e demais interessados a obtenção de outros dados e informações, a realização de análises, estudos e avaliações para fins de tomada de decisões, definição de estratégias de atuação, assunção de compromissos e obrigações e quaisquer outras finalidades, em qualquer tempo e sob qualquer condição. É proibida a reprodução ou utilização total ou parcial do presente sem a identificação da fonte.

Figura 1 - Precipitação observada (mm) no período de 08 a 13/02/2025

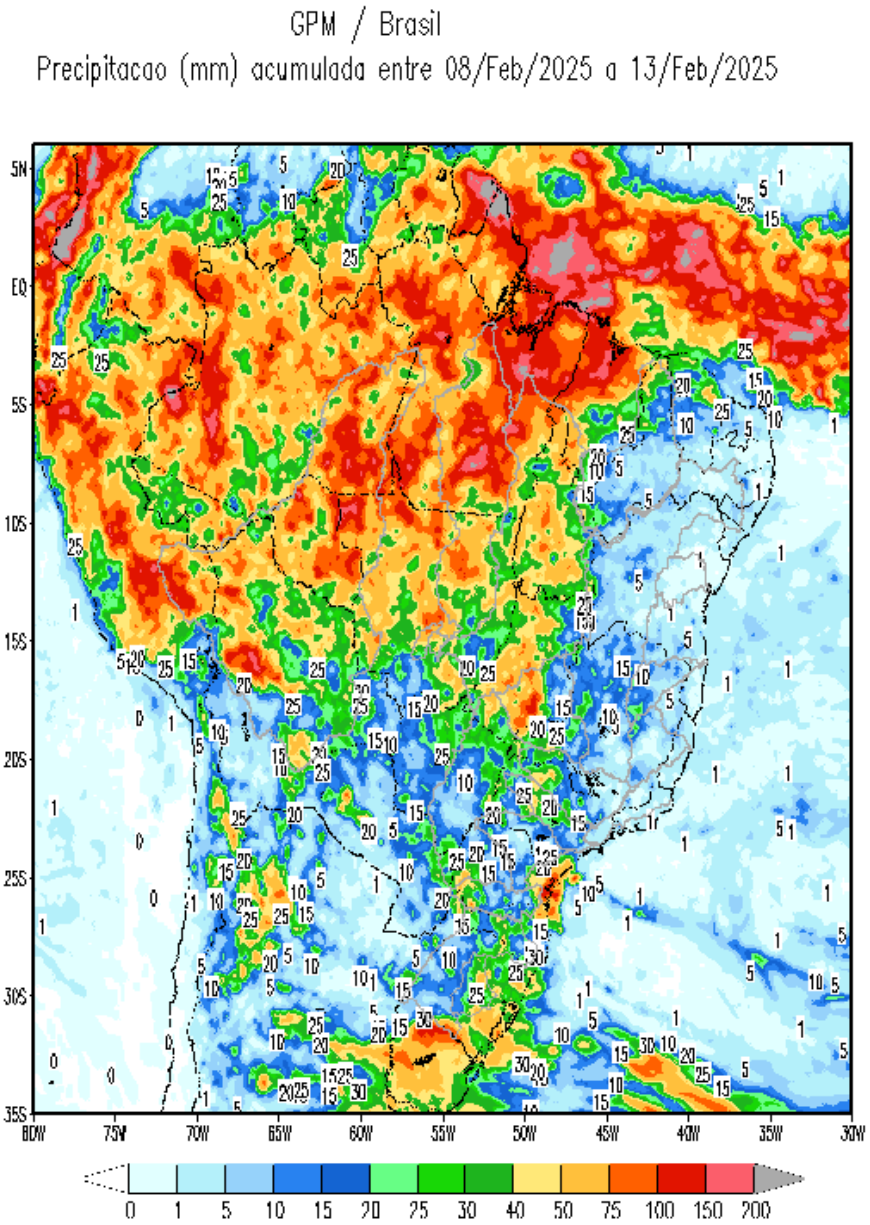

A **Tabela 1** apresenta as energias naturais afluentes das semanas recentes. São apresentados os valores verificados na semana 01/02/2025 a 07/02/2025 e os estimados para fechamento da semana de 08/02/2025 a 14/02/2025.

Tabela 1 – Tendência hidrológica da ENA da Revisão 2 de Fevereiro/2025

Revisão 2 do PMO de Fevereiro/2025 - ENAs				
Subsistema	01/02 a 07/02/2025		08/02 a 14/02/2025	
	MWmed	%MLT	MWmed	%MLT
SE/CO	70.305	99	69.727	98
S	6.845	83	6.443	78
NE	16.033	113	14.417	101
N	23.298	102	25.852	113

O conteúdo desta publicação foi produzido pelo ONS com base em dados e informações de conhecimento público. É de responsabilidade exclusiva dos agentes e demais interessados a obtenção de outros dados e informações, a realização de análises, estudos e avaliações para fins de tomada de decisões, definição de estratégias de atuação, assunção de compromissos e obrigações e quaisquer outras finalidades, em qualquer tempo e sob qualquer condição. É proibida a reprodução ou utilização total ou parcial do presente sem a identificação da fonte.

3.1.2. Previsões - Próxima semana

O avanço de uma frente fria pela Região Sul no início da semana e a atuação de áreas de instabilidade nas regiões Centro-Oeste e Norte no decorrer da semana ocasionam precipitação nas bacias dessas Regiões, sendo os maiores totais nas bacias dos rios Jacuí, Uruguai, Madeira, Tapajós e Xingu (Figura 2).

Figura 2 - Precipitação acumulada prevista pelo modelo ECMWF – 15 a 21/02/2025

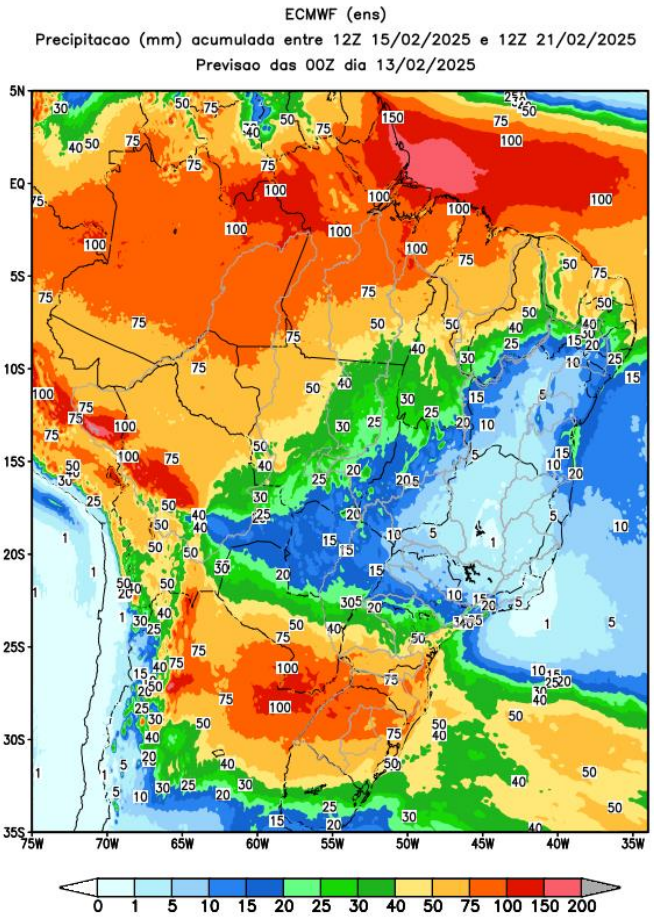

Em comparação com os valores estimados para a semana em curso, prevê-se para a próxima semana operativa ascensão nas afluências do subsistema Sul e recessão nas afluências dos subsistemas Sudeste/Centro-Oeste, Nordeste e Norte. A previsão mensal para fevereiro indica a ocorrência de afluências abaixo da média histórica para os subsistemas Sudeste/Centro-Oeste, Sul e Nordeste e acima da média histórica para o subsistema Norte.

Tabela 2 – Previsão de ENAs da Revisão 2 de Fevereiro/2025

Revisão 2 do PMO de Fevereiro/2025 - ENAs previstas				
Subsistema	15/02 a 21/02/2025		Mês de fevereiro	
	MWmed	%MLT	MWmed	%MLT
SE/CO	51.309	72	59.795	84
S	7.051	85	6.725	81
NE	11.946	84	12.780	90
N	25.431	112	25.335	111

O conteúdo desta publicação foi produzido pelo ONS com base em dados e informações de conhecimento público. É de responsabilidade exclusiva dos agentes e demais interessados a obtenção de outros dados e informações, a realização de análises, estudos e avaliações para fins de tomada de decisões, definição de estratégias de atuação, assunção de compromissos e obrigações e quaisquer outras finalidades, em qualquer tempo e sob qualquer condição. É proibida a reprodução ou utilização total ou parcial do presente sem a identificação da fonte.

As figuras a seguir ilustram as ENAs semanais verificadas e previstas para as Revisões 1 e 2 do PMO de Fevereiro/2025.

Figura 3 - Energias Naturais Afluentes ao Subsistema Sudeste/Centro-Oeste das Revisões 1 e 2 do PMO de Fevereiro/2025

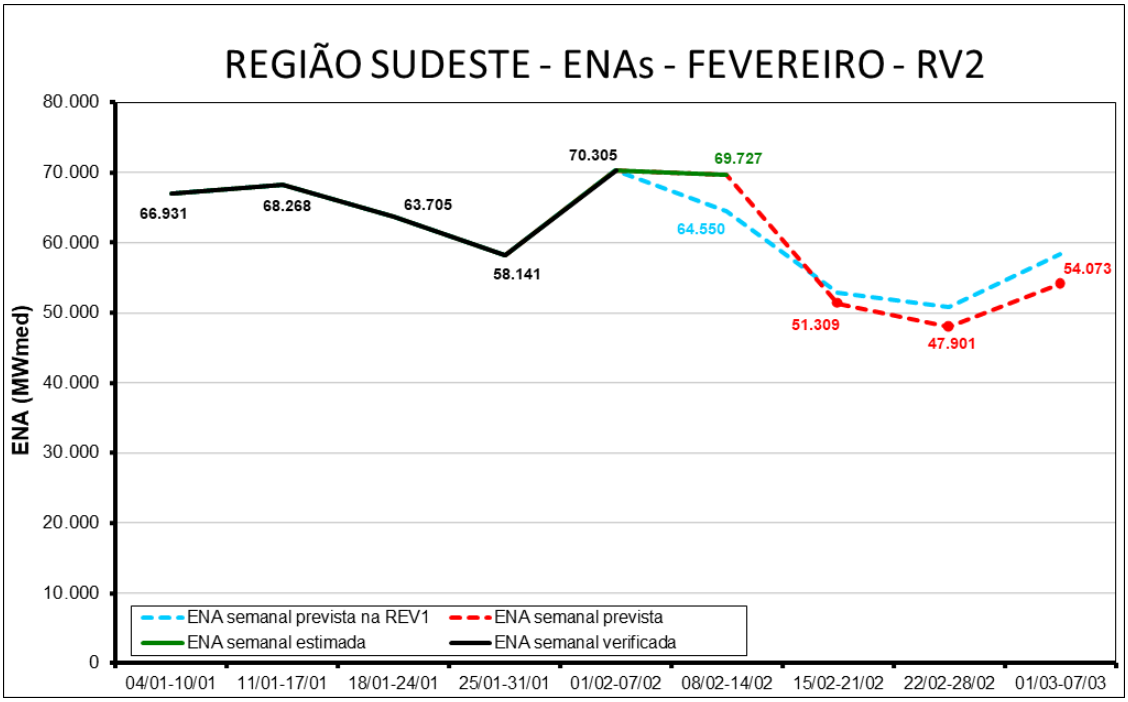

Figura 4 - Energias Naturais Afluentes ao Subsistema Sul das Revisões 1 e 2 do PMO de Fevereiro/2025

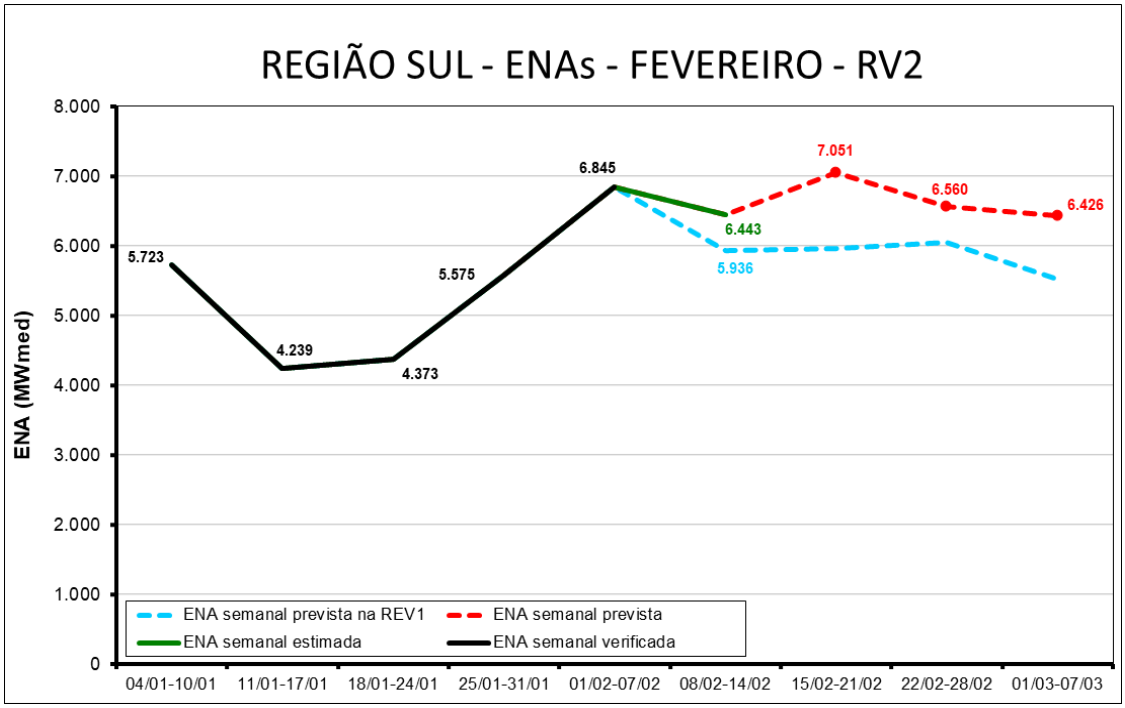

O conteúdo desta publicação foi produzido pelo ONS com base em dados e informações de conhecimento público. É de responsabilidade exclusiva dos agentes e demais interessados a obtenção de outros dados e informações, a realização de análises, estudos e avaliações para fins de tomada de decisões, definição de estratégias de atuação, assunção de compromissos e obrigações e quaisquer outras finalidades, em qualquer tempo e sob qualquer condição. É proibida a reprodução ou utilização total ou parcial do presente sem a identificação da fonte.

Figura 5 - Energias Naturais Afluentes ao Subsistema Nordeste das Revisões 1 e 2 do PMO de Fevereiro/2025

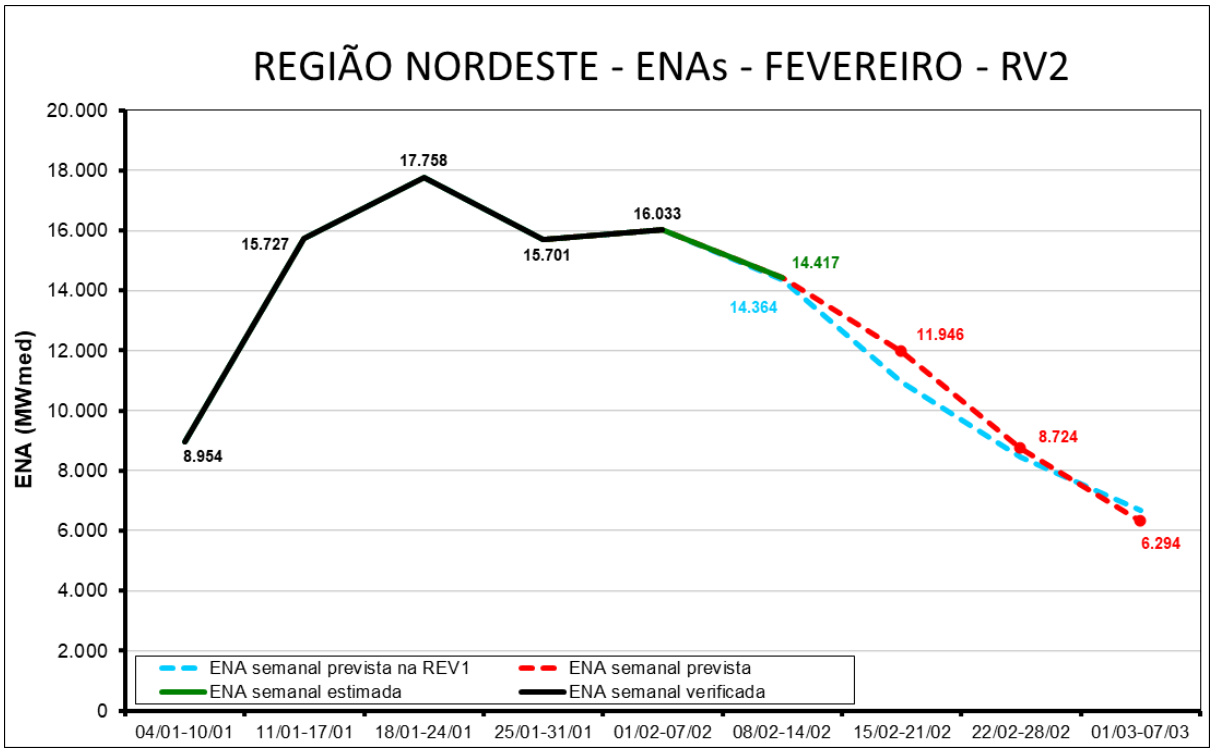

Figura 6 - Energias Naturais Afluentes ao Subsistema Norte das Revisões 1 e 2 do PMO de Fevereiro/2025

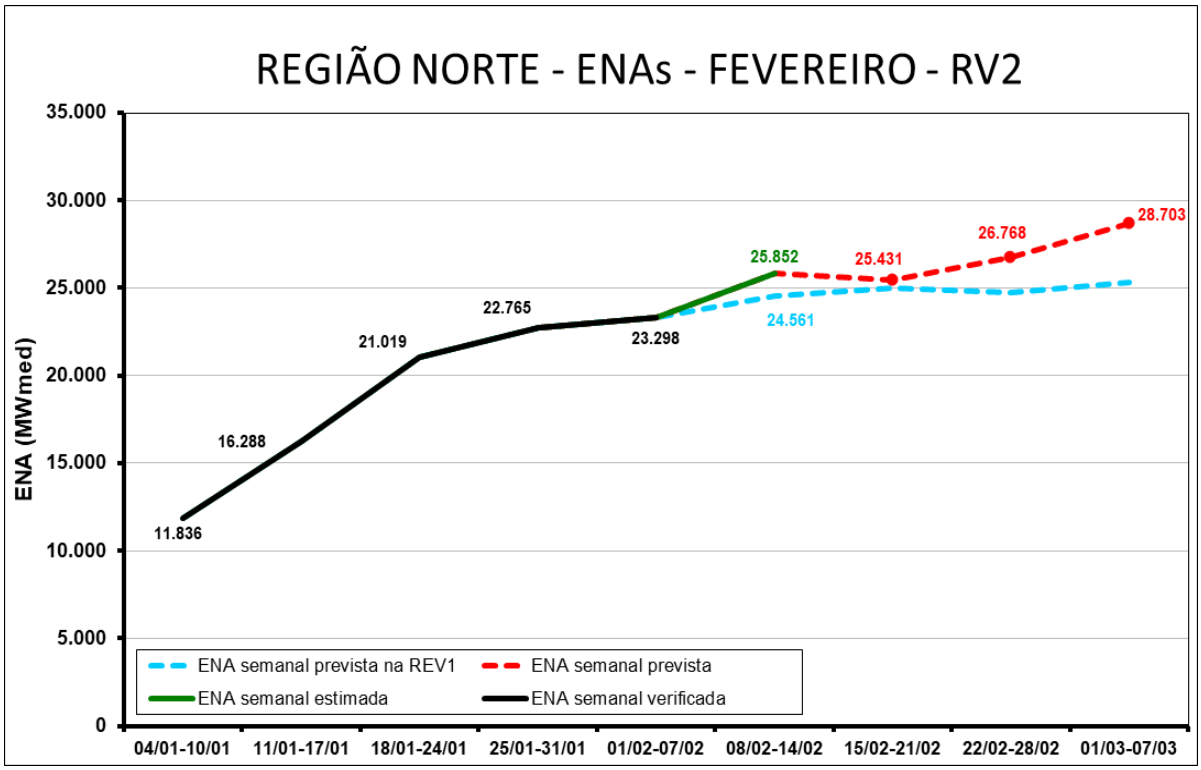

O conteúdo desta publicação foi produzido pelo ONS com base em dados e informações de conhecimento público. É de responsabilidade exclusiva dos agentes e demais interessados a obtenção de outros dados e informações, a realização de análises, estudos e avaliações para fins de tomada de decisões, definição de estratégias de atuação, assunção de compromissos e obrigações e quaisquer outras finalidades, em qualquer tempo e sob qualquer condição. É proibida a reprodução ou utilização total ou parcial do presente sem a identificação da fonte.

3.1.3. Cenários de ENAs para a Revisão 2 de Fevereiro/2025

As figuras a seguir apresentam as características dos cenários de energias naturais afluentes gerados na Revisão 2 de Fevereiro/2025, para acoplamento com a FCF do mês de março/2025. São mostradas, para os quatro subsistemas, as amplitudes e as Funções de Distribuição Acumulada dos cenários de ENA, comparativamente com os valores considerados para as revisões anteriores do PMO de Fevereiro/2025.

Figura 7 - Amplitude dos Cenários de ENA para o Subsistema Sudeste/Centro-Oeste, em %MLT, para a Revisão 2 de Fevereiro/2025

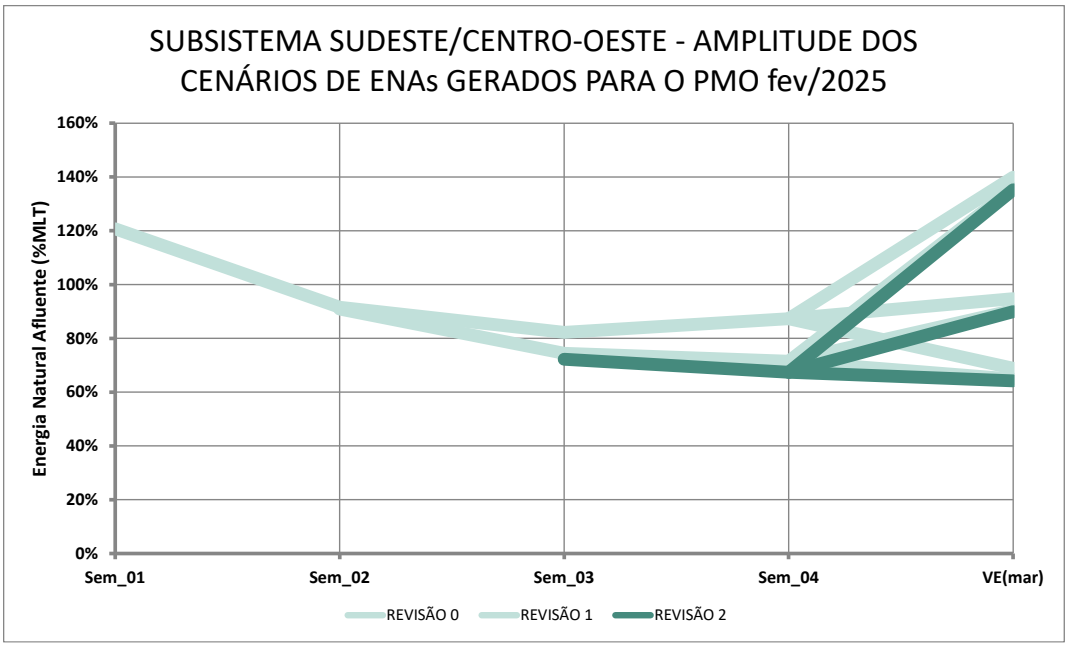

Figura 8 - Função de Distribuição Acumulada dos Cenários para o Subsistema Sudeste/Centro-Oeste para a Revisão 2 de Fevereiro/2025

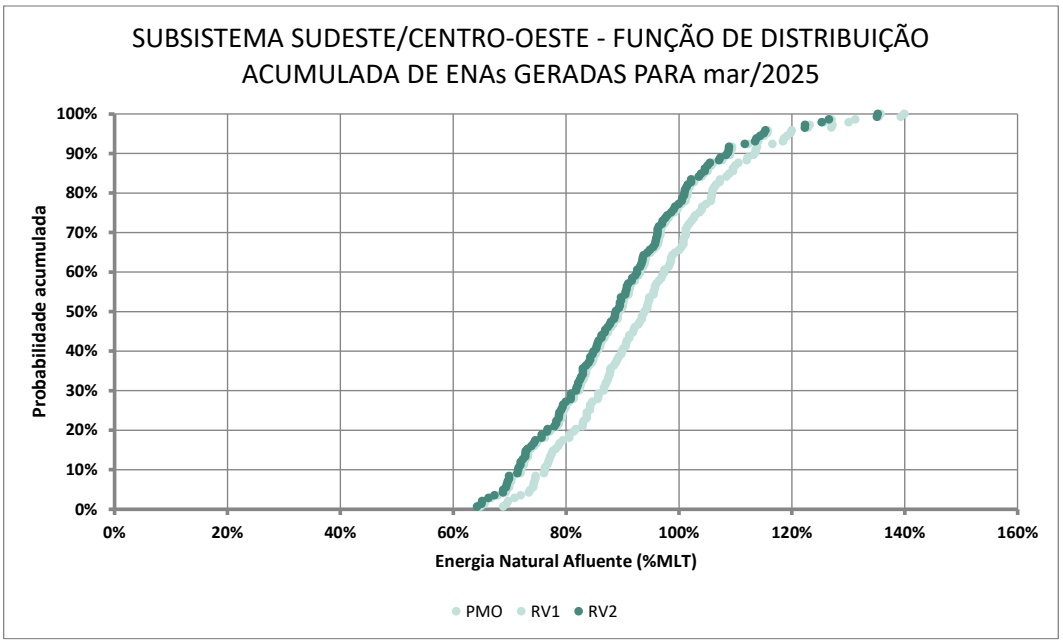

O conteúdo desta publicação foi produzido pelo ONS com base em dados e informações de conhecimento público. É de responsabilidade exclusiva dos agentes e demais interessados a obtenção de outros dados e informações, a realização de análises, estudos e avaliações para fins de tomada de decisões, definição de estratégias de atuação, assunção de compromissos e obrigações e quaisquer outras finalidades, em qualquer tempo e sob qualquer condição. É proibida a reprodução ou utilização total ou parcial do presente sem a identificação da fonte.

Figura 9 - Amplitude dos Cenários de ENA para o Subsistema Sul, em %MLT, para a Revisão 2 de Fevereiro/2025

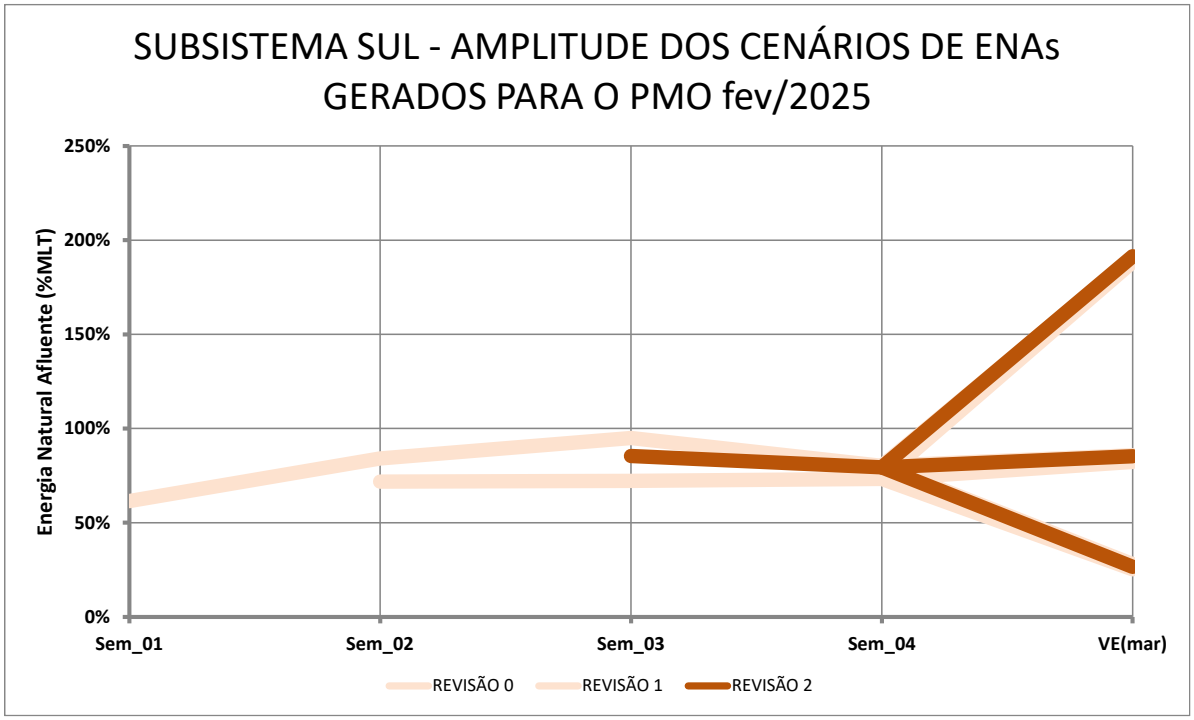

Figura 10 - Função de Distribuição Acumulada dos Cenários para o Subsistema Sul para a Revisão 2 de Fevereiro/2025

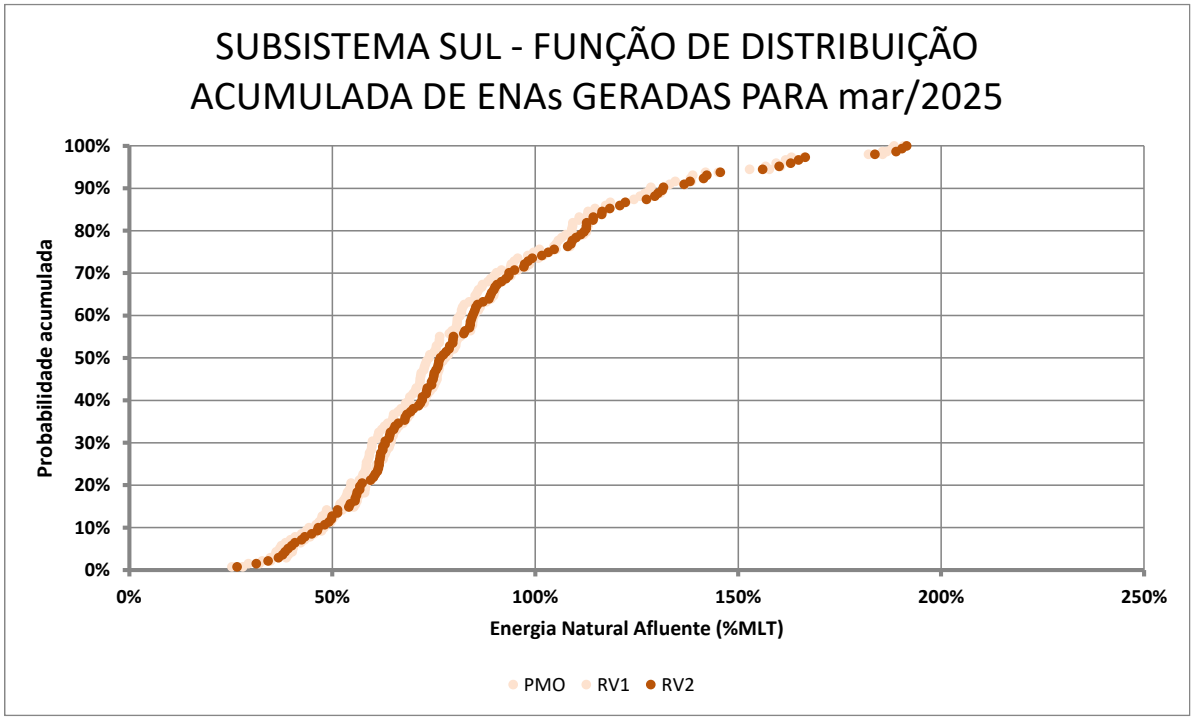

O conteúdo desta publicação foi produzido pelo ONS com base em dados e informações de conhecimento público. É de responsabilidade exclusiva dos agentes e demais interessados a obtenção de outros dados e informações, a realização de análises, estudos e avaliações para fins de tomada de decisões, definição de estratégias de atuação, assunção de compromissos e obrigações e quaisquer outras finalidades, em qualquer tempo e sob qualquer condição. É proibida a reprodução ou utilização total ou parcial do presente sem a identificação da fonte.

Figura 11 - Amplitude dos Cenários de ENA para o Subsistema Nordeste em %MLT, para a Revisão 2 de Fevereiro/2025

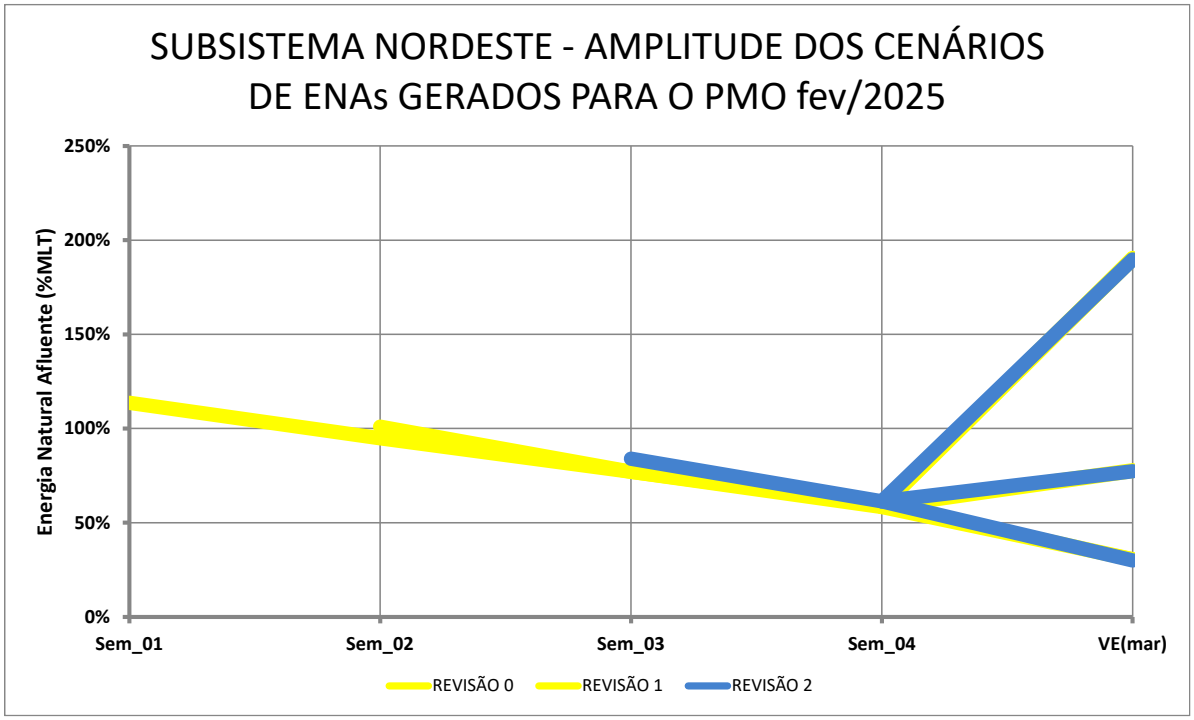

Figura 12 - Função de Distribuição Acumulada dos Cenários para o Subsistema Nordeste para a Revisão 2 de Fevereiro/2025

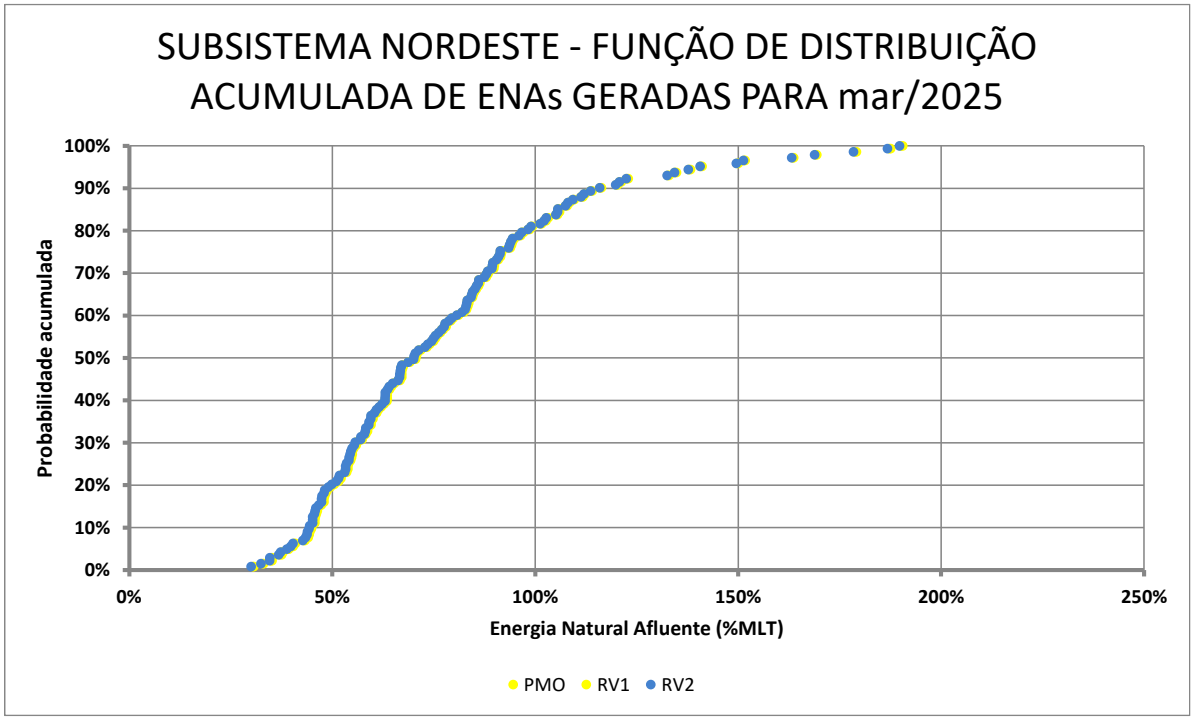

O conteúdo desta publicação foi produzido pelo ONS com base em dados e informações de conhecimento público. É de responsabilidade exclusiva dos agentes e demais interessados a obtenção de outros dados e informações, a realização de análises, estudos e avaliações para fins de tomada de decisões, definição de estratégias de atuação, assunção de compromissos e obrigações e quaisquer outras finalidades, em qualquer tempo e sob qualquer condição. É proibida a reprodução ou utilização total ou parcial do presente sem a identificação da fonte.

Figura 13 - Amplitude dos Cenários de ENA para o Subsistema Norte, em %MLT, para a Revisão 2 de Fevereiro/2025

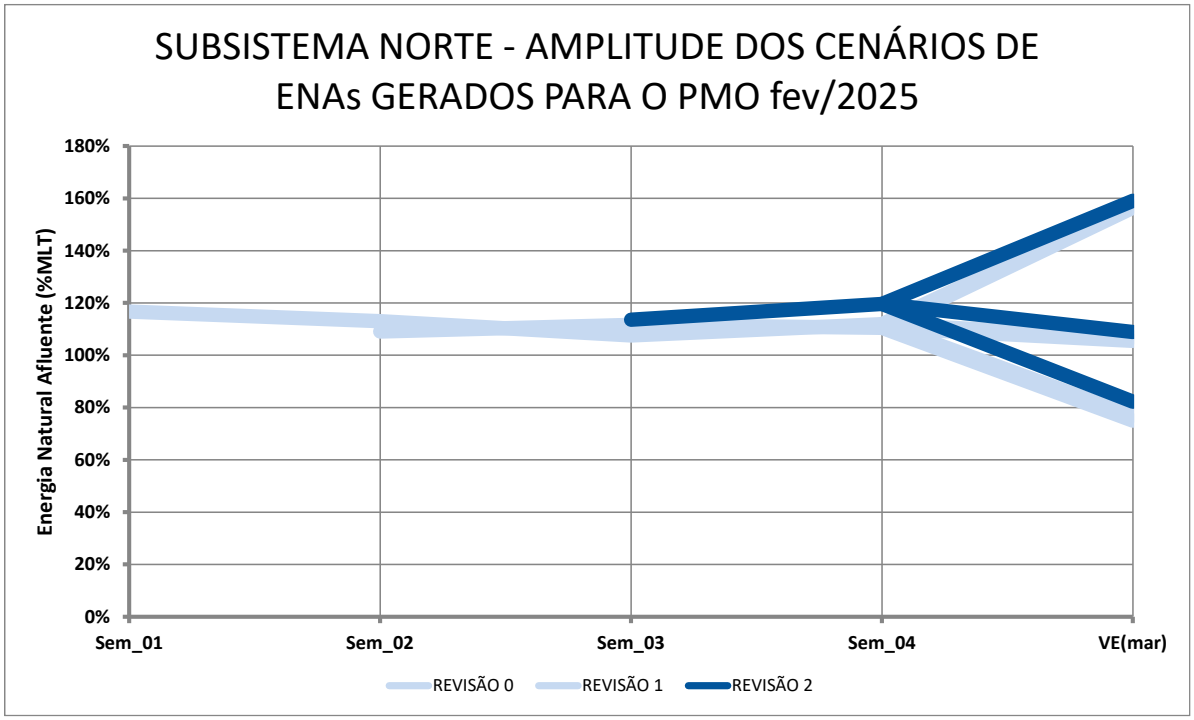

Figura 14 - Função de Distribuição Acumulada dos Cenários para o Subsistema Norte para a Revisão 2 de Fevereiro/2025

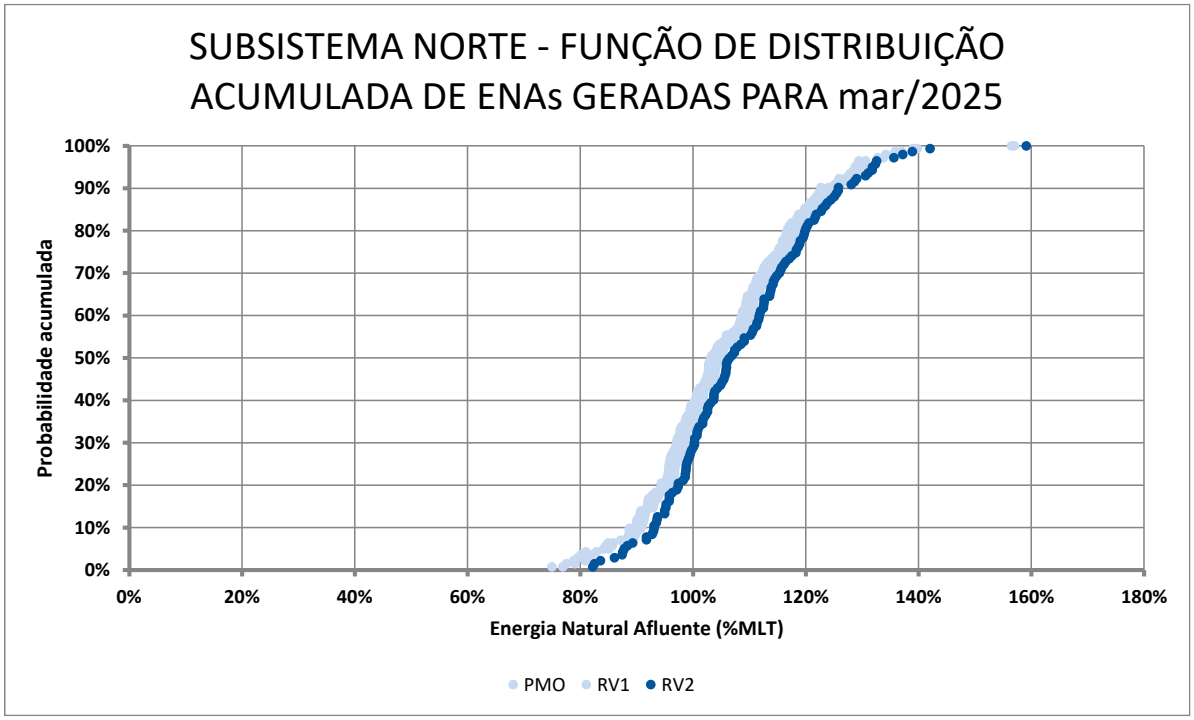

O conteúdo desta publicação foi produzido pelo ONS com base em dados e informações de conhecimento público. É de responsabilidade exclusiva dos agentes e demais interessados a obtenção de outros dados e informações, a realização de análises, estudos e avaliações para fins de tomada de decisões, definição de estratégias de atuação, assunção de compromissos e obrigações e quaisquer outras finalidades, em qualquer tempo e sob qualquer condição. É proibida a reprodução ou utilização total ou parcial do presente sem a identificação da fonte.

Os valores da MLT (Média de Longo Termo) das energias naturais afluentes para os meses de fevereiro/2025 e março/2025 são apresentados na tabela a seguir.

Tabela 3 – MLT da ENA nos meses de fevereiro/2025 e março/2025

MLT das ENAs (MWmed)		
Subsistema	fevereiro	março
SE/CO	71.087	69.259
S	8.260	7.077
NE	14.234	14.080
N	22.808	26.978

3.2. Limites de Intercâmbio entre Subsistemas

Os limites elétricos de intercâmbio de energia entre subsistemas são de fundamental importância para o processo de otimização energética, sendo determinantes para a definição das políticas de operação e do CMO para cada subsistema. Estes limites são influenciados por intervenções na malha de transmissão, notadamente na primeira semana operativa. O diagrama a seguir ilustra os fluxos notáveis do SIN e os limites aplicados neste PMO.

Figura 15 – Interligações entre regiões

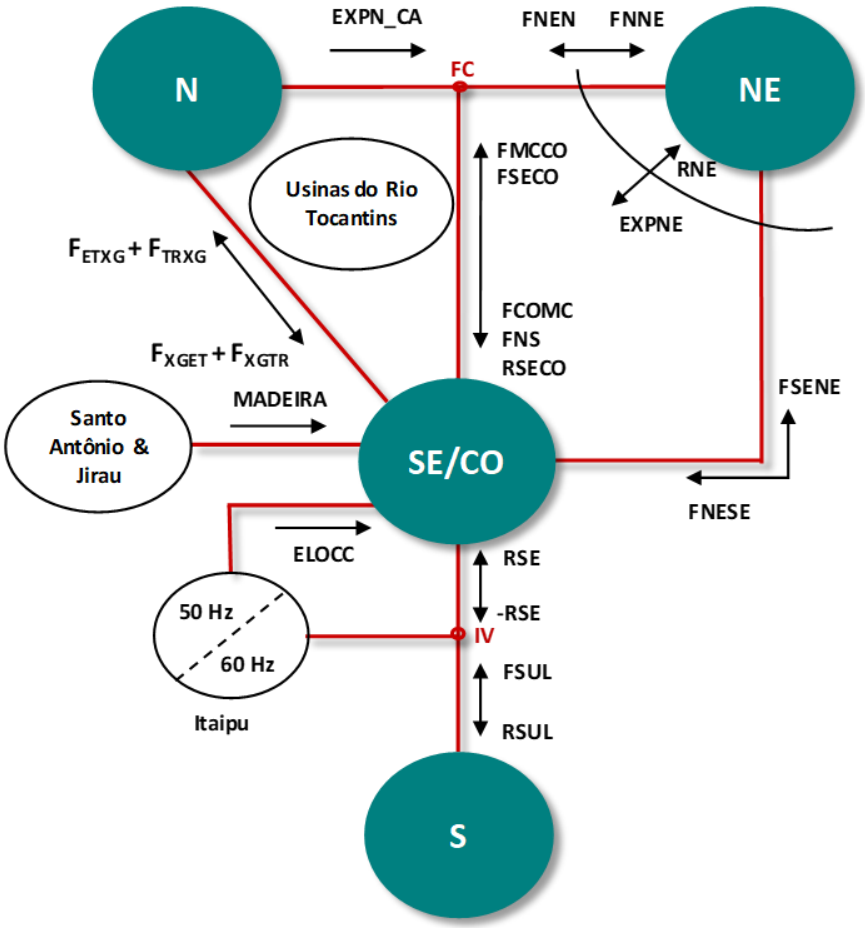

O conteúdo desta publicação foi produzido pelo ONS com base em dados e informações de conhecimento público. É de responsabilidade exclusiva dos agentes e demais interessados a obtenção de outros dados e informações, a realização de análises, estudos e avaliações para fins de tomada de decisões, definição de estratégias de atuação, assunção de compromissos e obrigações e quaisquer outras finalidades, em qualquer tempo e sob qualquer condição. É proibida a reprodução ou utilização total ou parcial do presente sem a identificação da fonte.

Tabela 4 – Limites considerados nesta semana operativa para intercâmbio de energia

Limites de Intercâmbio (MWmed)				
Fluxo	Patamar	15/02 a 21/02/2025		Demais Semanas
RNE	Pesada	11.000		11.000
	Média	11.000		11.000
	Leve	11.000		11.000
FNS	Pesada	3.050		3.050
	Média	3.050	(A)	3.050
	Leve	**2.954**		3.050
FNNE	Pesada	**4.800**		7.800
	Média	**4.800**	(B)	7.800
	Leve	**4.800**		7.800
EXPORT. NE	Pesada	13.800		13.800
	Média	13.800		13.800
	Leve	13.800		13.800
FMCCO	Pesada	5.000		5.000
	Média	5.000		5.000
	Leve	5.000		5.000
FSENE	Pesada	6.000		6.000
	Média	6.000		6.000
	Leve	6.000		6.000
FNS + FNESE	Pesada	**6.860**		7.160
	Média	**5.871**	(A) (C)	6.171
	Leve	**7.154**		7.550
RSE	Pesada	7.970		7.970
	Média	7.970	(D)	7.970
	Leve	**8.595**		9.030
FORNEC. SUL	Pesada	7.000		7.000
	Média	7.000		7.000
	Leve	7.000		7.000

Limites de Intercâmbio (MWmed)				
Fluxo	Patamar	15/02 a 21/02/2025		Demais Semanas
RECEB. SUL	Pesada	8.700		8.700
	Média	7.500	(D)	7.500
	Leve	**8.883**		9.100
ELO CC 50 Hz	Pesada	6.264		6.264
	Média	6.264		6.264
	Leve	6.264		6.264
ITAIPU 60 Hz	Pesada	7.500		7.500
	Média	7.500		7.500
	Leve	**7.123**		7.500
EXP. N CA	Pesada	8.000		8.000
	Média	8.000		8.000
	Leve	8.000		8.000
FETXG + FTRXG	Pesada	4.200		4.200
	Média	4.200		4.200
	Leve	4.200		4.200
FXGET + FXGTR	Pesada	8.000		8.000
	Média	8.000		8.000
	Leve	8.000		8.000
FNESE	Pesada	**5.200**		5.500
	Média	**3.721**	(A) (B) (C)	4.021
	Leve	**5.200**		5.500
FNEN	Pesada	**4.800**		5.600
	Média	**4.800**	(B)	5.600
	Leve	**4.800**		5.600
Ger_MADEIRA	Pesada	7.418		7.418
	Média	7.418		7.418
	Leve	7.418		7.418

(A) SGI 52.213-24
(B) SGI 3.922-25
(C) SGI 76.389-24
(D) SGI 6.403-25

O conteúdo desta publicação foi produzido pelo ONS com base em dados e informações de conhecimento público. É de responsabilidade exclusiva dos agentes e demais interessados a obtenção de outros dados e informações, a realização de análises, estudos e avaliações para fins de tomada de decisões, definição de estratégias de atuação, assunção de compromissos e obrigações e quaisquer outras finalidades, em qualquer tempo e sob qualquer condição. É proibida a reprodução ou utilização total ou parcial do presente sem a identificação da fonte.

3.3. Previsão de carga

As projeções atualizadas para o mês de fevereiro indicam acréscimos de 6,4% no Subsistema Sudeste/Centro-Oeste, 8,6% no Subsistema Sul, 1,5% no Subsistema Nordeste e 4,0% no Subsistema Norte em relação ao mesmo mês do ano anterior. Os principais fatores estão descritos a seguir.

A estimativa do fechamento da carga global de energia na semana operativa atual (08/02 a 14/02) aponta que a carga segue impactada pelas temperaturas elevadas e baixos acumulados de precipitação, acarretando ondas de calor que atingem as regiões Sudeste e Sul. A seguir, são apresentadas as justificativas para os resultados observados em cada Subsistema.

A carga estimada para a semana atual no Subsistema Sudeste/Centro-Oeste segue acima do esperado, com valor superior a 50.000 MWmed. A retomada das atividades escolares, associada à onda de calor em capitais como Rio de Janeiro e São Paulo, foi determinante para esse resultado. No Subsistema Sul, os dias quentes também se destacaram, especialmente no Rio Grande do Sul. Porto Alegre e o sudoeste do estado registraram temperaturas elevadas, refletindo diretamente na carga desta semana.

No Subsistema Nordeste, o acréscimo de carga observado decorre da transição de uma semana com acumulados relevantes de precipitação (semana 1) para uma semana mais seca (semana 2). No Subsistema Norte, o comportamento da carga tem sido semelhante no comparativo semanal, em função da manutenção das temperaturas e acumulados de precipitação, resultando em um desvio de apenas 0,2%.

Para a próxima semana, as projeções indicam ajustes nos valores de carga para todos os subsistemas, visando maior aderência ao comportamento recente e às sinalizações meteorológicas. No Sudeste/Centro-Oeste, o elevado nível de carga nas últimas semanas, somado às previsões de altas temperaturas e baixa precipitação, propiciaram um aumento de 4% nas previsões. No Sul, as novas projeções realizadas indicam para a próxima semana uma carga entre os níveis das semanas 1 e 2, pois a previsão de precipitação é superior à vigente. Nos subsistemas Norte e Nordeste, os ajustes buscam alinhar a carga às condições atuais, considerando a maior previsão de precipitação no Nordeste e estabilidade no Norte.

Tabela 5 – Evolução da carga do PMO de Fevereiro de 2025

Subsistema	CARGA SEMANAL (MWmed)				CARGA MENSAL (MWmed)	
	1ª Sem	2ª Sem	3ª Sem	4ª Sem	fev/25	Var. (%) fev/25 -> fev/24
SE/CO	48.641	50.812	50.858	49.890	50.050	6,4%
Sul	16.800	17.292	16.969	16.574	16.909	8,6%
Nordeste	13.289	13.634	13.405	13.647	13.494	1,5%
Norte	7.661	7.622	7.679	7.676	7.660	4,0%
SIN	**86.392**	**89.360**	**88.911**	**87.787**	**88.113**	**5,8%**

O conteúdo desta publicação foi produzido pelo ONS com base em dados e informações de conhecimento público. É de responsabilidade exclusiva dos agentes e demais interessados a obtenção de outros dados e informações, a realização de análises, estudos e avaliações para fins de tomada de decisões, definição de estratégias de atuação, assunção de compromissos e obrigações e quaisquer outras finalidades, em qualquer tempo e sob qualquer condição. É proibida a reprodução ou utilização total ou parcial do presente sem a identificação da fonte.

3.4. Potência Hidráulica Total Disponível no SIN

O gráfico a seguir mostra a disponibilidade hidráulica total do SIN, para este mês, de acordo com o cronograma de manutenção informado pelos agentes para esta Revisão.

Figura 16 – Potência hidráulica disponível no SIN

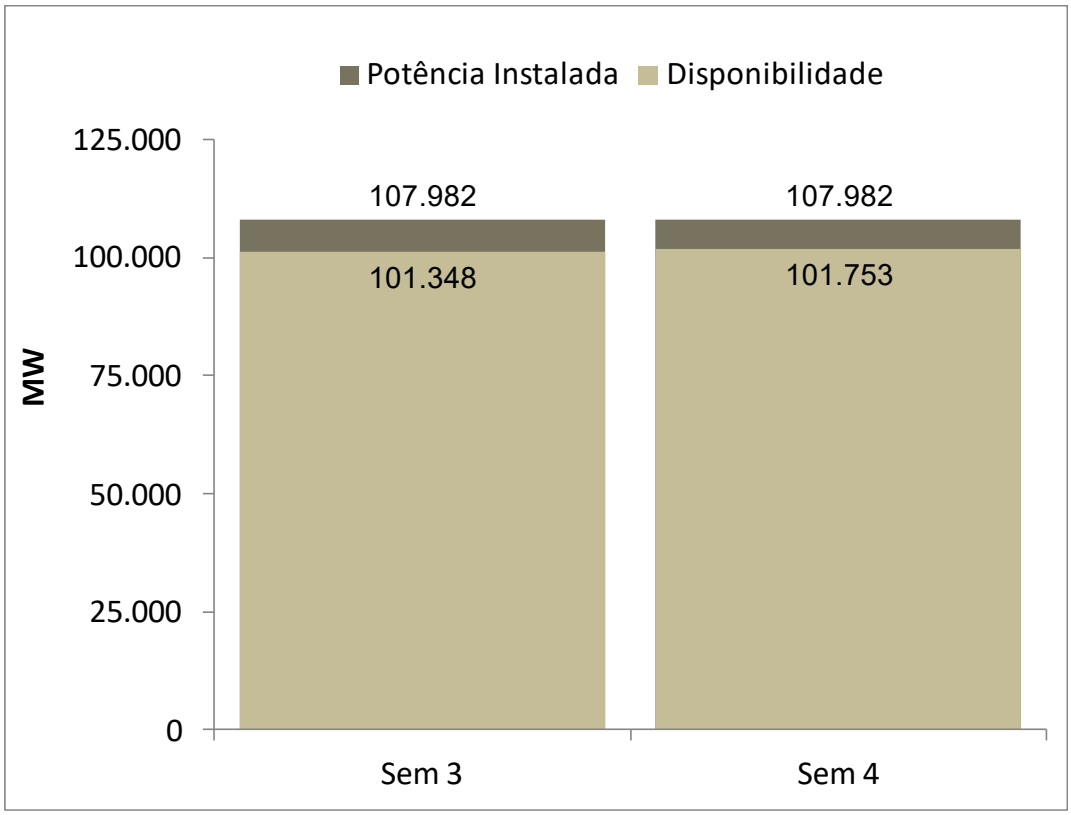

3.5. Armazenamentos Iniciais por Subsistema

Tabela 6 – Armazenamentos iniciais, por subsistema, considerados para esta semana operativa

Armazenamento (%EARmáx) - 0:00 h do dia 15/02/2025		
Subsistema	**Nível previsto na Revisão 1 do PMO Fev/2025**	**Partida informada pelos Agentes para a Revisão 2 do PMO Fev/2025**
SE/CO	69,3	67,6
S	60,1	57,6
NE	77,8	77,9
N	95,1	90,9

A primeira coluna da tabela acima corresponde ao armazenamento previsto na Revisão 1 do PMO de Fevereiro de 2025, para a 0:00 h do dia 15/02/2025. A segunda coluna apresenta os armazenamentos obtidos a partir dos níveis de partida informados pelos Agentes de Geração para seus aproveitamentos com reservatórios.

O conteúdo desta publicação foi produzido pelo ONS com base em dados e informações de conhecimento público. É de responsabilidade exclusiva dos agentes e demais interessados a obtenção de outros dados e informações, a realização de análises, estudos e avaliações para fins de tomada de decisões, definição de estratégias de atuação, assunção de compromissos e obrigações e quaisquer outras finalidades, em qualquer tempo e sob qualquer condição. É proibida a reprodução ou utilização total ou parcial do presente sem a identificação da fonte.

4. PRINCIPAIS RESULTADOS

4.1. Política de Operação Energética

Para esta semana operativa, está prevista a seguinte política de intercâmbio de energia entre regiões:

Região SE/CO:

- Utilização dos recursos das bacias dos rios Grande, Paranaíba e Paraná, conforme necessidade de alocação na carga e controle de nível nas usinas de cabeceira dos rios Grande e Paranaíba.

Região Sul:

- Utilização da geração hidráulica das bacias do Iguaçu, Jacuí e Uruguai conforme necessidade para atendimento da carga e os controles de limites elétricos.

Região NE:

- Operação minimizada visando o replecionamento dos reservatórios e maior alocação das gerações dos demais subsistemas.

Região Norte:

- Subsistema exportador de energia em todos os patamares;

- Exploração das usinas das bacias do rio Tocantins e do rio Xingu, respeitando-se as restrições operativas e os limites elétricos vigentes;

- Operação minimizada na UHE Balbina.

4.2. Custo Marginal de Operação – CMO

A figura a seguir apresenta os Custos Marginais de Operação, em valores médios semanais, para as semanas operativas deste mês.

Figura 17 – CMO em valores médios

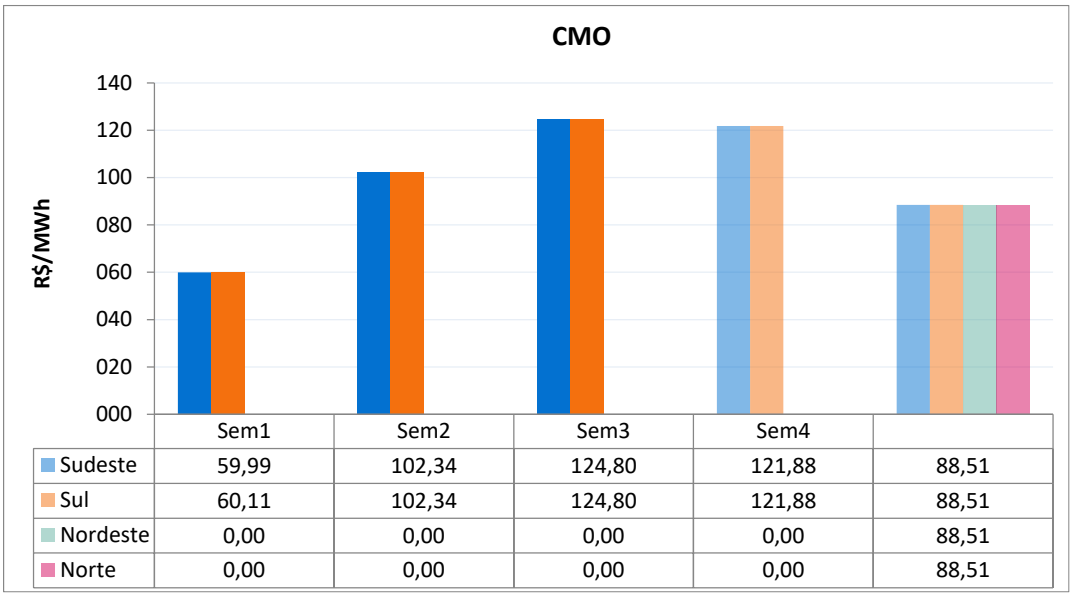

	Sem1	Sem2	Sem3	Sem4	
Sudeste	59,99	102,34	124,80	121,88	88,51
Sul	60,11	102,34	124,80	121,88	88,51
Nordeste	0,00	0,00	0,00	0,00	88,51
Norte	0,00	0,00	0,00	0,00	88,51

A tabela a seguir apresenta o custo marginal de operação, por subsistema e patamar de carga, para a próxima semana operativa.

O conteúdo desta publicação foi produzido pelo ONS com base em dados e informações de conhecimento público. É de responsabilidade exclusiva dos agentes e demais interessados a obtenção de outros dados e informações, a realização de análises, estudos e avaliações para fins de tomada de decisões, definição de estratégias de atuação, assunção de compromissos e obrigações e quaisquer outras finalidades, em qualquer tempo e sob qualquer condição. É proibida a reprodução ou utilização total ou parcial do presente sem a identificação da fonte.

Tabela 7 – CMO para esta semana operativa

Patamares de Carga	CMO (R$/MWh)			
	SE/CO	S	NE	N
Pesada	128,85	128,85	0,00	0,00
Média	126,18	126,18	0,00	0,00
Leve	121,27	121,27	0,00	0,00
Média Semanal	124,80	124,80	0,00	0,00

4.3. Energia Armazenada

O processo de otimização realizado pelo programa DECOMP indicou os armazenamentos mostrados na figura a seguir para as próximas semanas operativas do mês de fevereiro/2025.

Figura 18 – Energias Armazenadas nas semanas operativas do mês de fevereiro/2025

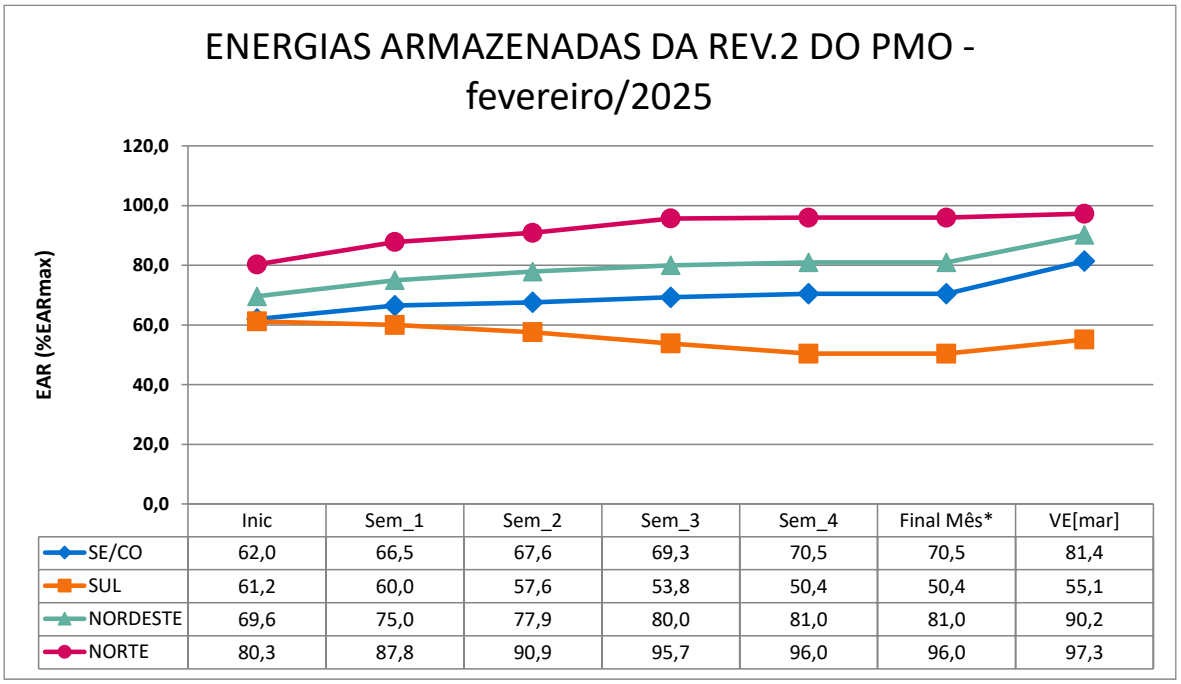

Os armazenamentos da figura anterior estão expressos em percentual da Energia Armazenável Máxima de cada subsistema, que são mostradas na tabela a seguir.

Tabela 8 – Energia Armazenável Máxima por subsistema no PMO de Fevereiro/2025

ENERGIA ARMAZENÁVEL MÁXIMA (MWmed)		
Subsistema	fevereiro	março
SE/CO	205.460	205.460
S	20.458	20.458
NE	51.718	51.718
N	15.820	15.755

O conteúdo desta publicação foi produzido pelo ONS com base em dados e informações de conhecimento público. É de responsabilidade exclusiva dos agentes e demais interessados a obtenção de outros dados e informações, a realização de análises, estudos e avaliações para fins de tomada de decisões, definição de estratégias de atuação, assunção de compromissos e obrigações e quaisquer outras finalidades, em qualquer tempo e sob qualquer condição. É proibida a reprodução ou utilização total ou parcial do presente sem a identificação da fonte.

5. GERAÇÃO TÉRMICA

A Figura 19 apresenta, para cada subsistema do SIN, o despacho térmico por modalidade indicado pelo Decomp para esta semana operativa.

Figura 19 – Geração térmica para a próxima semana operativa

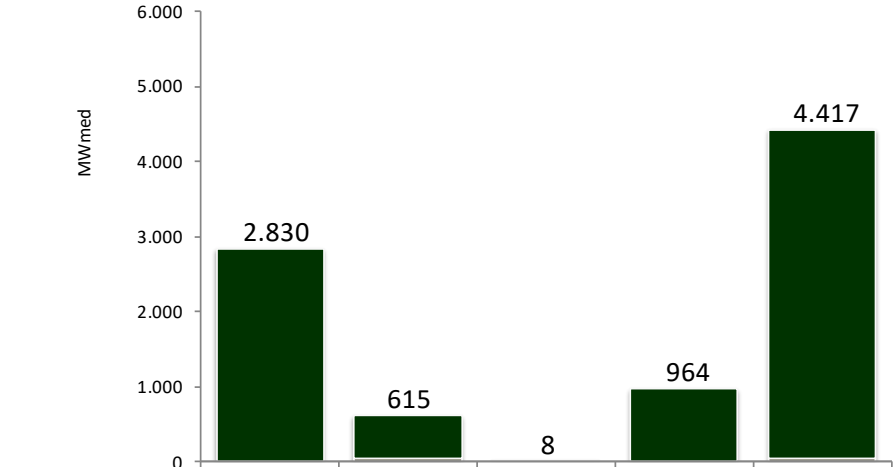

	SE/CO	SUL	NE	NORTE	SIN
RESTRIÇÃO ELÉTRICA	0	0	0	0	0
INFLEXIBILIDADE	2830	566	8	964	4368
ORDEM DE MÉRITO	0	49	0	0	49

Na tabela abaixo segue a Indicação de despacho antecipado por ordem de mérito de custo para a semana de 19/04/2025 a 25/04/2025.

Tabela 9 – UTEs com contrato de combustível GNL

UTE			Benefício (R$/MWh)			Despacho antecipado por mérito		
Nome	Código	CVU (R$/MWh)	Carga Pesada	Carga Média	Carga Leve	Carga Pesada	Carga Média	Carga Leve
SANTA CRUZ	86	268,00	92,91	90,68	88,02	Não	Não	Não
LUIZORMELO	15	408,50	92,91	90,68	88,02	Não	Não	Não
PSERGIPE I	224	398,34	64,02	60,53	59,88	Não	Não	Não

Assim sendo, não há previsão de despacho antecipado por ordem de mérito de custo para as UTE Santa Cruz, Luiz O. R. Melo e Porto Sergipe I, para a semana de 19/04/2025 a 25/04/2025.

O conteúdo desta publicação foi produzido pelo ONS com base em dados e informações de conhecimento público. É de responsabilidade exclusiva dos agentes e demais interessados a obtenção de outros dados e informações, a realização de análises, estudos e avaliações para fins de tomada de decisões, definição de estratégias de atuação, assunção de compromissos e obrigações e quaisquer outras finalidades, em qualquer tempo e sob qualquer condição. É proibida a reprodução ou utilização total ou parcial do presente sem a identificação da fonte.

6. RESUMO DOS RESULTADOS DO PMO

As figuras a seguir apresentam um resumo dos resultados da Revisão 2 de Fevereiro/2025, com informações da Energia Natural Afluente (ENA), da Energia Armazenada (EAR) e do Custo Marginal de Operação (CMO) nos subsistemas do Sistema Interligado Nacional (SIN). São apresentados os valores semanais observados e previstos e o valor esperado dos cenários gerados para o mês de março/2025.

Figura 20 – Resumo de fevereiro/2025 para o Subsistema Sudeste/Centro-Oeste

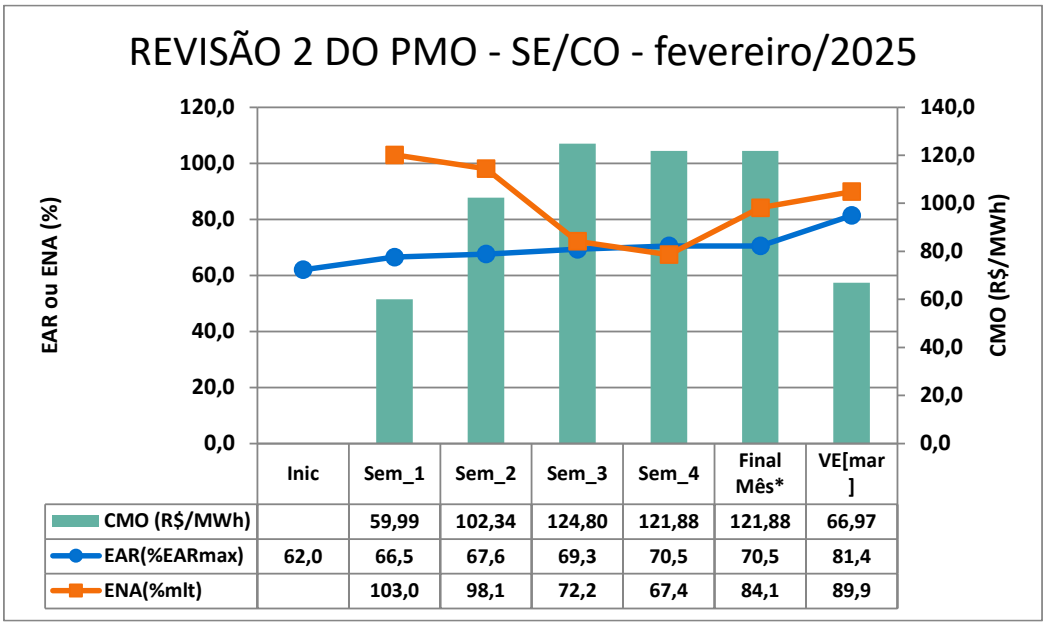

	Inic	Sem_1	Sem_2	Sem_3	Sem_4	Final Mês*	VE[mar]
CMO (R$/MWh)		59,99	102,34	124,80	121,88	121,88	66,97
EAR(%EARmax)	62,0	66,5	67,6	69,3	70,5	70,5	81,4
ENA(%mlt)		103,0	98,1	72,2	67,4	84,1	89,9

Figura 21 – Resumo de fevereiro/2025 para o Subsistema Sul

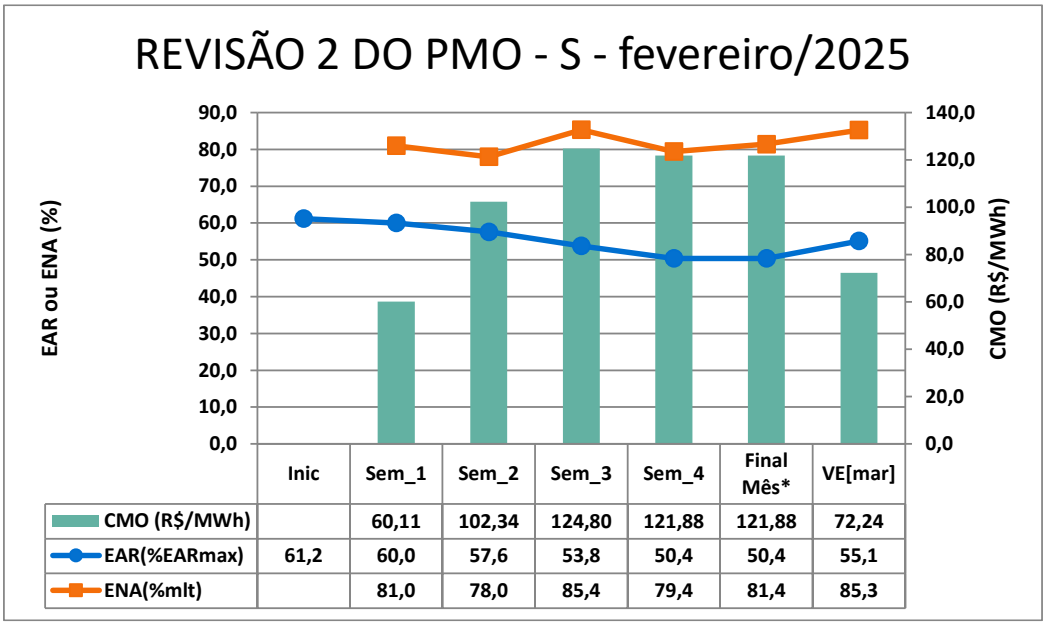

	Inic	Sem_1	Sem_2	Sem_3	Sem_4	Final Mês*	VE[mar]
CMO (R$/MWh)		60,11	102,34	124,80	121,88	121,88	72,24
EAR(%EARmax)	61,2	60,0	57,6	53,8	50,4	50,4	55,1
ENA(%mlt)		81,0	78,0	85,4	79,4	81,4	85,3

O conteúdo desta publicação foi produzido pelo ONS com base em dados e informações de conhecimento público. É de responsabilidade exclusiva dos agentes e demais interessados a obtenção de outros dados e informações, a realização de análises, estudos e avaliações para fins de tomada de decisões, definição de estratégias de atuação, assunção de compromissos e obrigações e quaisquer outras finalidades, em qualquer tempo e sob qualquer condição. É proibida a reprodução ou utilização total ou parcial do presente sem a identificação da fonte.

Figura 22 – Resumo de fevereiro/2025 para o Subsistema Nordeste

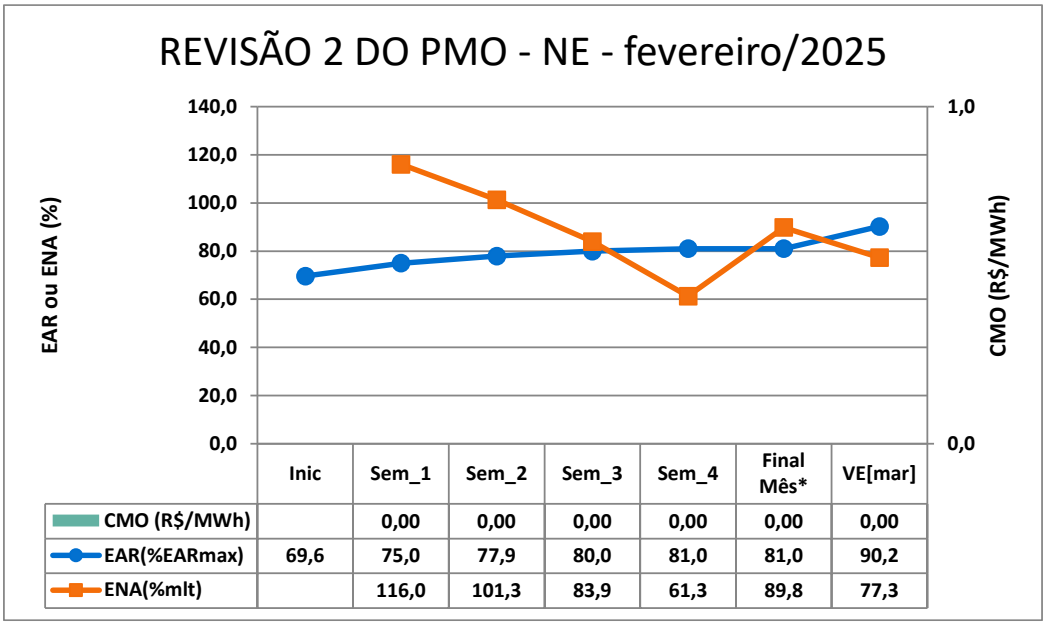

	Inic	Sem_1	Sem_2	Sem_3	Sem_4	Final Mês*	VE[mar]
CMO (R$/MWh)		0,00	0,00	0,00	0,00	0,00	0,00
EAR(%EARmax)	69,6	75,0	77,9	80,0	81,0	81,0	90,2
ENA(%mlt)		116,0	101,3	83,9	61,3	89,8	77,3

Figura 23 – Resumo de fevereiro/2025 para o Subsistema Norte

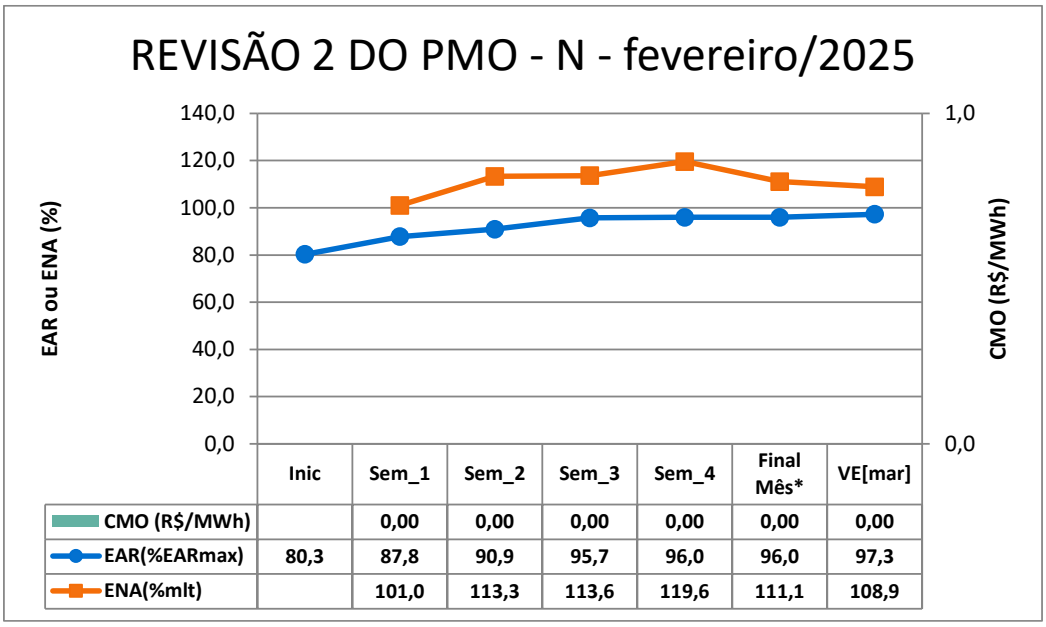

	Inic	Sem_1	Sem_2	Sem_3	Sem_4	Final Mês*	VE[mar]
CMO (R$/MWh)		0,00	0,00	0,00	0,00	0,00	0,00
EAR(%EARmax)	80,3	87,8	90,9	95,7	96,0	96,0	97,3
ENA(%mlt)		101,0	113,3	113,6	119,6	111,1	108,9

O conteúdo desta publicação foi produzido pelo ONS com base em dados e informações de conhecimento público. É de responsabilidade exclusiva dos agentes e demais interessados a obtenção de outros dados e informações, a realização de análises, estudos e avaliações para fins de tomada de decisões, definição de estratégias de atuação, assunção de compromissos e obrigações e quaisquer outras finalidades, em qualquer tempo e sob qualquer condição. É proibida a reprodução ou utilização total ou parcial do presente sem a identificação da fonte.

7. ARMAZENAMENTOS OPERATIVOS

Para uma melhor avaliação de diversos cenários hidrometeorológicos, notadamente, aqueles de curto prazo e suas influências nas previsões de vazões nos subsistemas, os resultados desta Revisão do PMO contemplam cenários de afluências visando melhor representar a ocorrência de precipitação e, consequentemente, seus efeitos sobre as afluências e armazenamentos.

Apresentamos a seguir as correspondentes energias naturais afluentes e os resultados obtidos com a aplicação do cenário de afluência utilizado no estudo.

Tabela 10 – Previsão de ENA do caso de valor esperado das previsões de afluência

Subsistema	ENERGIAS NATURAIS AFLUENTES			
	Previsão Semanal		Previsão Mensal	
	(MWmed)	%MLT	(MWmed)	%MLT
SE/CO	51.309	72	59.795	84
Sul	7.051	85	6.725	81
Nordeste	11.946	84	12.780	90
Norte	25.431	112	25.335	111

Tabela 11 – Previsão de %EARmáx para o final do mês

Subsistema	% EARmáx 14/02	% EARmáx - 28/02
	NÍVEL INICIAL	NÍVEL PMO
SE/CO	67,6	70,5
Sul	57,6	50,4
Nordeste	77,9	81,0
Norte	90,9	96,0

O conteúdo desta publicação foi produzido pelo ONS com base em dados e informações de conhecimento público. É de responsabilidade exclusiva dos agentes e demais interessados a obtenção de outros dados e informações, a realização de análises, estudos e avaliações para fins de tomada de decisões, definição de estratégias de atuação, assunção de compromissos e obrigações e quaisquer outras finalidades, em qualquer tempo e sob qualquer condição. É proibida a reprodução ou utilização total ou parcial do presente sem a identificação da fonte.

8. RESERVATÓRIOS EQUIVALENTES DE ENERGIA

A seguir são apresentadas as previsões de Energia Natural Afluente para a próxima semana operativa e para o mês de fevereiro, bem como as previsões de Energia Armazenada nos Reservatórios Equivalentes de Energia – REE, desta revisão do PMO de Fevereiro de 2025.

Tabela 12 – Previsão de ENA por REE

Valor Esperado das Energias Naturais Afluentes				
REE	Previsão Semanal		Previsão Mensal	
	15/02/2025 a 21/02/2025		fev/25	
	(MWmed)	%MLT	(MWmed)	%MLT
Sudeste	5.985	57	7.836	74
Madeira	10.329	98	10.325	98
Teles Pires	4.198	105	3.905	98
Itaipu	2.302	58	1.728	43
Paraná	25.779	68	32.398	85
Paranapanema	2.717	72	3.631	96
Sul	3.210	82	2.741	70
Iguaçu	3.841	88	3.985	91
Nordeste	11.946	84	12.780	90
Norte	12.242	96	12.758	100
Belo Monte	12.104	132	11.728	128
Manaus	1.565	182	1.288	150

Tabela 13 – Previsão de %EARmáx por REE

% Energia Armazenável Máxima		
REE	Previsão Semanal	Previsão Mensal
	21-fev	28-fev
	(%EARmáx)	(%EARmáx)
Sudeste	69,9	70,7
Madeira	65,1	70,5
Teles Pires	57,8	65,4
Itaipu	39,9	-
Paraná	69,0	70,8
Paranapanema	73,8	71,2
Sul	43,2	41,4
Iguaçu	64,2	59,2
Nordeste	80,0	81,0
Norte	100,0	100,0
Belo Monte	89,7	100,0
Manaus	13,6	20,2

O conteúdo desta publicação foi produzido pelo ONS com base em dados e informações de conhecimento público. É de responsabilidade exclusiva dos agentes e demais interessados a obtenção de outros dados e informações, a realização de análises, estudos e avaliações para fins de tomada de decisões, definição de estratégias de atuação, assunção de compromissos e obrigações e quaisquer outras finalidades, em qualquer tempo e sob qualquer condição. É proibida a reprodução ou utilização total ou parcial do presente sem a identificação da fonte.

9. DESPACHO TÉRMICO POR MODALIDADE, PATAMAR DE CARGA E USINA

Nas tabelas abaixo, a diferenciação entre geração por inflexibilidade e por ordem de mérito tem caráter informativo, com o objetivo de detalhar a informação de inflexibilidade enviada pelos respectivos agentes para esta Revisão do PMO. Ressalta-se que nas etapas de Programação Diária e Tempo Real, o montante despachado nas usinas termelétricas indicadas por ordem de mérito é plenamente intitulado como ordem de mérito.

Tabela 14 – Despachos de Geração Térmica

REGIÃO SUDESTE/CENTRO-OESTE																	
Térmicas Potência (MW)	Combustível	CVU	Inflexibilidade			Ordem de Mérito			Total Mérito e INFL.			Razão Elétrica			Total UTE		
			P	M	L	P	M	L	P	M	L	P	M	L	P	M	L
ATLAN_CSA (255)	Resíduos	0,00	100,7	100,7	100,7				100,7	100,7	100,7				100,7	100,7	100,7
DAIA (44)	Diesel	---															
TNORTE 2 (349)	Óleo	---															
VIANA (175)	Óleo	---															
W.ARJONA O (177)	Diesel	---															
XAVANTES (54)	Diesel	---															
ANGRA 2 (1350)	Nuclear	20,12	1350,0	1350,0	1350,0				1350,0	1350,0	1350,0				1350,0	1350,0	1350,0
ANGRA 1 (640)	Nuclear	31,17	640,0	640,0	640,0				640,0	640,0	640,0				640,0	640,0	640,0
O.PINTADA (50)	Biomassa	145,52															
UTE STA VI (41)	Biomassa	157,20															
M.AZUL (566)	Gás	178,92	475,0	475,0	475,0				475,0	475,0	475,0				475,0	475,0	475,0
ATLANTICO (235)	Resíduos	250,89	218,7	218,7	218,7				218,7	218,7	218,7				218,7	218,7	218,7
BAIXADA FL (530)	Gás	263,95															
SANTA CRUZ (500)	GNL	268,00															
ST.CRUZ 34 (436)	Óleo	310,41															
LUIZORMELO (204)	GNL	408,50															
PIRAT.12 O (200)	Gás	470,34															
UTE GNA I (1338)	Gás	515,01															
CUBATAO (216)	Gás	535,40															
NORTEFLU (826)	Gás	954,00															
T.MACAE (922)	Gás	954,52															
IBIRITE (235)	Gás	984,23															
TERMORIO (989)	Gás	1069,98															
KARKEY 013 (259)	Gás	1085,76	30,0	30,0	30,0				30,0	30,0	30,0				30,0	30,0	30,0
KARKEY 019 (116)	Gás	1085,76															
T.LAGOAS (350)	Gás	1177,96															
PORSUD II (78)	Gás	1264,60															
PORSUD I (116)	Gás	1267,14															
CUIABA CC (529)	Gás	1310,74															
J.FORA (87)	Gás	1422,31															
PALMEIR_GO (176)	Diesel	1436,84															
SEROPEDICA (360)	Gás	1439,02															
PAULINIA (16)	Gás	1557,89	15,7	15,7	15,7				15,7	15,7	15,7				15,7	15,7	15,7
LORM_PCS (36)	Gás	1595,79															
POVOACAO I (75)	Gás	1595,79															
VIANA I (37)	Gás	1595,79															
NPIRATINGA (572)	Gás	1720,29															
W.ARJONA (177)	Gás	1847,46															
TOTAL SE/CO (13316)			2830,1	2830,1	2830,1	0,0	0,0	0,0	2830,1	2830,1	2830,1	0,0	0,0	0,0	2830,1	2830,1	2830,1

REGIÃO SUL																	
Térmicas Potência (MW)	Combustível	CVU	Inflexibilidade			Ordem de Mérito			Total Mérito e INFL.			Razão Elétrica			Total UTE		
			P	M	L	P	M	L	P	M	L	P	M	L	P	M	L
CANDIOTA_3 (350)	Carvão	---															
PAMPA SUL (345)	Carvão	101,20	300,0	300,0	300,0	45,0	45,0	45,0	345,0	345,0	345,0				345,0	345,0	345,0
SAO SEPE (8)	Biomassa	113,53	4,0	4,0	4,0	4,0	4,0	4,0	8,0	8,0	8,0				8,0	8,0	8,0
FIGUEIRA (20)	Carvão	330,64															
J.LACER. C (330)	Carvão	341,04	120,0	126,0	96,0				120,0	126,0	96,0				120,0	126,0	96,0
J.LACER. B (220)	Carvão	397,24	88,0	92,0	71,0				88,0	92,0	71,0				88,0	92,0	71,0
J.LAC. A2 (110)	Carvão	406,63	40,0	42,0	32,0				40,0	42,0	32,0				40,0	42,0	32,0
J.LAC. A1 (80)	Carvão	475,13	32,0	34,0	26,0				32,0	34,0	26,0				32,0	34,0	26,0
B.BONITA I (10)	Gás	778,35															
ARAUCARIA (484)	Gás	956,04															
URUGUAIANA (640)	Gás	1119,76															
CANOAS (249)	Gás	1364,49															
TOTAL SUL (2846)			584,0	598,0	529,0	49,0	49,0	49,0	633,0	647,0	578,0	0,0	0,0	0,0	633,0	647,0	578,0

O conteúdo desta publicação foi produzido pelo ONS com base em dados e informações de conhecimento público. É de responsabilidade exclusiva dos agentes e demais interessados a obtenção de outros dados e informações, a realização de análises, estudos e avaliações para fins de tomada de decisões, definição de estratégias de atuação, assunção de compromissos e obrigações e quaisquer outras finalidades, em qualquer tempo e sob qualquer condição. É proibida a reprodução ou utilização total ou parcial do presente sem a identificação da fonte.

REGIÃO NORDESTE

Térmicas Potência (MW)	Combustível	CVU	Inflexibilidade			Ordem de Mérito			Total Mérito e INFL.			Razão Elétrica			Total UTE		
			P	M	L	P	M	L	P	M	L	P	M	L	P	M	L
CAMPINA_GR (169)	Óleo	---															
GLOBAL I (149)	Óleo	---															
GLOBAL II (149)	Óleo	---															
MARACANAU (168)	Óleo	---															
PETROLINA (136)	Óleo	---															
POTIGUAR (53)	Diesel	---															
POTIGUAR_3 (66)	Diesel	---															
TERMOCABO (50)	Óleo	---															
TERMONE (171)	Óleo	---															
TERMOPB (171)	Óleo	---															
ERB CANDEI (17)	Biomassa	113,61	3,5	3,5	3,5				3,5	3,5	3,5				3,5	3,5	3,5
PROSP_I (28)	Gás	214,28															
PROSP_III (56)	Gás	218,33															
P.PECEM1 (720)	Carvão	377,23															
P.PECEM2 (365)	Carvão	383,07															
PSERGIPE I (1593)	GNL	398,34															
PROSP_II (37)	Gás	398,72	4,0	4,0	4,0				4,0	4,0	4,0				4,0	4,0	4,0
VALE ACU (110)	Gás	450,86															
PERNAMBU_3 (201)	Óleo	1051,26															
TERMOPE (550)	Gás	1094,73															
T.BAHIA (186)	Gás	1106,03															
SUAPE II (381)	Óleo	1246,77															
TERMOCEARA (223)	Gás	2040,21															
C.MURICY 2 (144)	Óleo	2966,67															
PECEM 2 (144)	Óleo	2997,80															
TOTAL NE (5749)			7,5	7,5	7,5	0,0	0,0	0,0	7,5	7,5	7,5	0,0	0,0	0,0	7,5	7,5	7,5

REGIÃO NORTE

Térmicas Potência (MW)	Combustível	CVU	Inflexibilidade			Ordem de Mérito			Total Mérito e INFL.			Razão Elétrica			Total UTE		
			P	M	L	P	M	L	P	M	L	P	M	L	P	M	L
C. ROCHA (85)	Gás	0,00	65,0	65,0	65,0				65,0	65,0	65,0				65,0	65,0	65,0
GERAMAR1 (166)	Óleo	---															
GERAMAR2 (166)	Óleo	---															
JARAQUI (75)	Gás	0,00	63,0	63,0	63,0				63,0	63,0	63,0				63,0	63,0	63,0
MANAUARA (73)	Gás	0,00	73,0	73,0	73,0				73,0	73,0	73,0				73,0	73,0	73,0
PONTA NEGR (73)	Gás	0,00	64,0	64,0	64,0				64,0	64,0	64,0				64,0	64,0	64,0
TAMBAQUI (93)	Gás	0,00	63,0	63,0	63,0				63,0	63,0	63,0				63,0	63,0	63,0
MARANHAO3 (519)	Gás	110,91	10,0	55,0	10,0				10,0	55,0	10,0				10,0	55,0	10,0
APARECIDA (166)	Gás	128,22	75,0	75,0	75,0				75,0	75,0	75,0				75,0	75,0	75,0
UTE MAUA 3 (591)	Gás	128,22	264,0	264,0	264,0				264,0	264,0	264,0				264,0	264,0	264,0
MARANHAO V (338)	Gás	247,22	75,0	60,0	40,0				75,0	60,0	40,0				75,0	60,0	40,0
MARANHAOIV (338)	Gás	247,22	75,0	60,0	40,0				75,0	60,0	40,0				75,0	60,0	40,0
PARNAIBA_V (386)	Vapor	248,15	110,0	85,0	55,0				110,0	85,0	55,0				110,0	85,0	55,0
N.VENECIA2 (270)	Gás	300,53	96,0	75,0	45,0				96,0	75,0	45,0				96,0	75,0	45,0
P. ITAQUI (360)	Carvão	374,93															
PARNAIB_IV (56)	Gás	558,26	20,0	15,0	10,0				20,0	15,0	10,0				20,0	15,0	10,0
TOTAL NORTE (4045)			1053,0	1017,0	867,0	0,0	0,0	0,0	1053,0	1017,0	867,0	0,0	0,0	0,0	1053,0	1017,0	867,0

O conteúdo desta publicação foi produzido pelo ONS com base em dados e informações de conhecimento público. É de responsabilidade exclusiva dos agentes e demais interessados a obtenção de outros dados e informações, a realização de análises, estudos e avaliações para fins de tomada de decisões, definição de estratégias de atuação, assunção de compromissos e obrigações e quaisquer outras finalidades, em qualquer tempo e sob qualquer condição. É proibida a reprodução ou utilização total ou parcial do presente sem a identificação da fonte.