1. APRESENTAÇÃO

No início da semana de 26/06 a 02/07/2021 o avanço de uma frente fria pela região Sul ocasionou precipitação de intensidade fraca à moderada nas bacias dos rios Jacuí, Uruguai e Iguaçu. Na região Norte, áreas de instabilidade ocasionaram precipitação no baixo Xingu.

Na semana de 03/07 a 09/07/2021 deve ocorrer um período de estiagem nas bacias hidrográficas da região Sul devido à a atuação de um sistema de alta pressão. Na região Norte, continua o padrão observado na semana anterior, com a ocorrência de pancadas de chuva isoladas no final da cascata do Xingu e do Tocantins. Prevê-se para esta semana operativa recessão nas afluências dos subsistemas Sudeste/Centro-Oeste, Sul e Norte e estabilidade nas afluências do subsistema Nordeste.

Para a semana operativa de 03/07 a 09/07/2021, houve oferta de energia da República Oriental do Uruguai e da República da Argentina. De acordo com o Art. 2º da Portaria MME nº 339, de 15 de agosto de 2018, as ofertas para importação de energia não foram consideradas na elaboração do PMO.

Os valores médios semanais do Custo Marginal de Operação – CMO dos subsistemas do SIN sofreram as seguintes alterações em relação à semana anterior:

- SE/CO: de R$ 944,55/MWh para R$ 957,12/MWh
- Sul: de R$ 944,55/MWh para R$ 957,12/MWh
- Nordeste: de R$ 944,55/MWh para R$ 957,12/MWh
- Norte: de R$ 944,55/MWh para R$ 957,12/MWh

Desde o dia 01/01/2020, o despacho por ordem de mérito é indicado diariamente pelos resultados do modelo DESSEM. Assim, o despacho por ordem de mérito semanal, conforme publicado nesse documento, tem caráter apenas informativo. Da mesma forma, desde o dia 01/01/2021, a formação de preço deixou o formato semanal/patamar de carga e passou a ser horário, de acordo também com os resultados do modelo DESSEM.

2. NOTÍCIAS

Nos dias 29 e 30 de julho será realizada a reunião de elaboração do PMO de Agosto de 2021, com transmissão ao vivo através do site do ONS.

Como medida adicional de prevenção ao Coronavírus, o ONS informa que está suspensa, temporariamente, a participação presencial nas reuniões.

O conteúdo desta publicação foi produzido pelo ONS com base em dados e informações de conhecimento público. É de responsabilidade exclusiva dos agentes e demais interessados a obtenção de outros dados e informações, a realização de análises, estudos e avaliações para fins de tomada de decisões, definição de estratégias de atuação, assunção de compromissos e obrigações e quaisquer outras finalidades, em qualquer tempo e sob qualquer condição. É proibida a reprodução ou utilização total ou parcial do presente sem a identificação da fonte.

3. ANÁLISE DAS CONDIÇÕES HIDROMETEOROLÓGICAS

3.1. PREVISÃO PARA A PRÓXIMA SEMANA

Na próxima semana operativa a atuação de um sistema de alta pressão na região Sul ocasiona um período de estiagem nas bacias hidrográficas dessa região. Na região Norte, continua o padrão observado na semana operativa anterior, com a ocorrência de pancadas de chuva isoladas no final da cascata do Xingu e do Tocantins (**Figura 1**).

Figura 1 - Precipitação acumulada prevista pelo modelo ECMWF (ECMWF) para o período de 03/07/2021 a 09/07/2021.

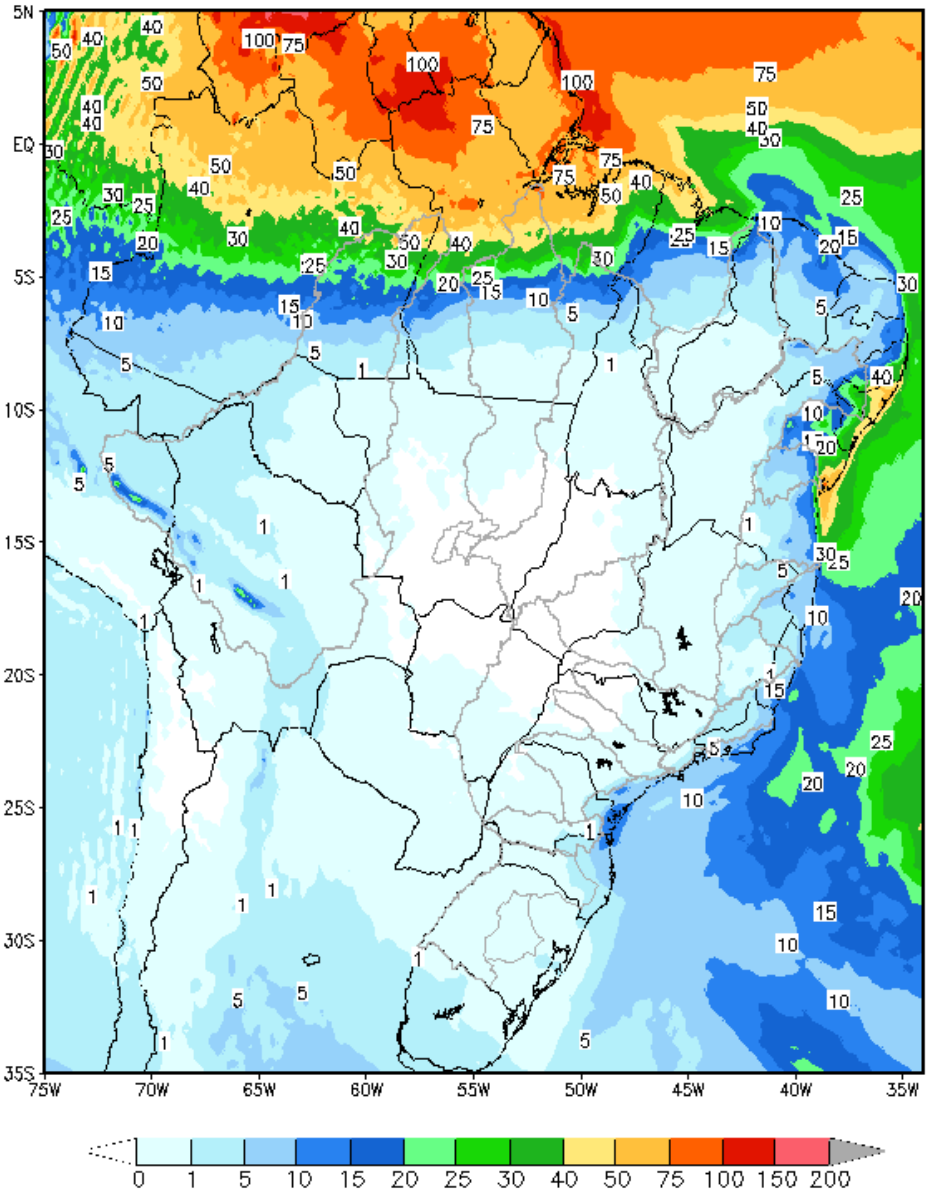

Em comparação com os valores estimados para a semana em curso, prevê-se para a próxima semana operativa recessão nas afluências dos subsistemas Sudeste/Centro-Oeste, Sul e Norte e estabilidade nas afluências do subsistema Nordeste. A previsão mensal para julho indica a ocorrência de afluências abaixo da média histórica para todos os subsistemas.

O conteúdo desta publicação foi produzido pelo ONS com base em dados e informações de conhecimento público. É de responsabilidade exclusiva dos agentes e demais interessados a obtenção de outros dados e informações, a realização de análises, estudos e avaliações para fins de tomada de decisões, definição de estratégias de atuação, assunção de compromissos e obrigações e quaisquer outras finalidades, em qualquer tempo e sob qualquer condição. É proibida a reprodução ou utilização total ou parcial do presente sem a identificação da fonte.

Tabela 1 – Previsão de ENAs da Revisão 1 de Julho/2021

Revisão 1 do PMO de Julho/2021 - ENAs previstas				
Subsistema	03/07 a 09/07/2021		Mês de julho	
	MWmed	%MLT	MWmed	%MLT
SE/CO	17.255	67	16.052	62
S	6.772	62	6.210	57
NE	1.633	43	1.606	42
N	4.752	90	4.144	79

4. PREVISÃO DE CARGA

A expectativa de que o setor industrial se mantenha em patamares elevados principalmente daquelas indústrias voltadas para exportação, e a melhora dos setores comercial e serviços em função do avanço da campanha de vacinação, conforme os indicadores de confiança disponibilizados pela FGV em maio/21, estão se refletindo nas projeções de carga realizadas para o mês de julho/21.

Durante a semana operativa em curso, o avanço de uma massa de ar polar acarretou temperaturas baixas em grande parte do país, inferiores às consideradas como premissas para elaboração das projeções de carga.

As previsões meteorológicas indicam para a próxima semana operativa, temperaturas levemente superiores às observadas na semana atual em todos os subsistemas.

As taxas de crescimento previstas para o mês de julho em relação ao mesmo mês do ano anterior, são de 2,9% para os subsistemas Sudeste/Centro-Oeste, 3,4% para o subsistema Sul, 6,9% no Nordeste e 7,6% no subsistema do Norte.

Tabela 2 – Evolução da carga do PMO de Julho 2021

Subsistema	CARGA SEMANAL (MWmed)						CARGA MENSAL (MWmed)	
	1ª Sem	2ª Sem	3ª Sem	4ª Sem	5ª Sem	6ª Sem	jul/21	Var. (%) jul/21 -> jul/20
SE/CO	36.531	37.214	37.783	38.003	38.200	38.398	37.738	2,9%
Sul	11.347	11.476	11.481	11.489	11.492	11.502	11.476	3,4%
Nordeste	10.689	10.808	10.747	10.757	10.766	10.770	10.764	6,9%
Norte	5.783	5.877	5.879	5.889	5.895	5.907	5.879	7,6%
SIN	**64.350**	**65.375**	**65.890**	**66.138**	**66.353**	**66.577**	**65.857**	**4,0%**

O conteúdo desta publicação foi produzido pelo ONS com base em dados e informações de conhecimento público. É de responsabilidade exclusiva dos agentes e demais interessados a obtenção de outros dados e informações, a realização de análises, estudos e avaliações para fins de tomada de decisões, definição de estratégias de atuação, assunção de compromissos e obrigações e quaisquer outras finalidades, em qualquer tempo e sob qualquer condição. É proibida a reprodução ou utilização total ou parcial do presente sem a identificação da fonte.

5. PRINCIPAIS RESULTADOS

5.1. CUSTO MARGINAL DE OPERAÇÃO (CMO)

A tabela a seguir apresenta o CMO, por subsistema e patamar de carga para próxima semana operativa.

Tabela 3 – CMO por patamar de carga

Patamares de Carga	CMO (R$/MWh)			
	SE/CO	S	NE	N
Pesada	970,77	970,77	970,77	970,77
Média	967,12	967,12	967,12	967,12
Leve	941,81	941,81	941,81	941,81
Média Semanal	957,12	957,12	957,12	957,12

Na figura a seguir é apresentada a evolução do CMO médio semanal ao longo deste PMO.

Figura 2 – Evolução semanal do CMO

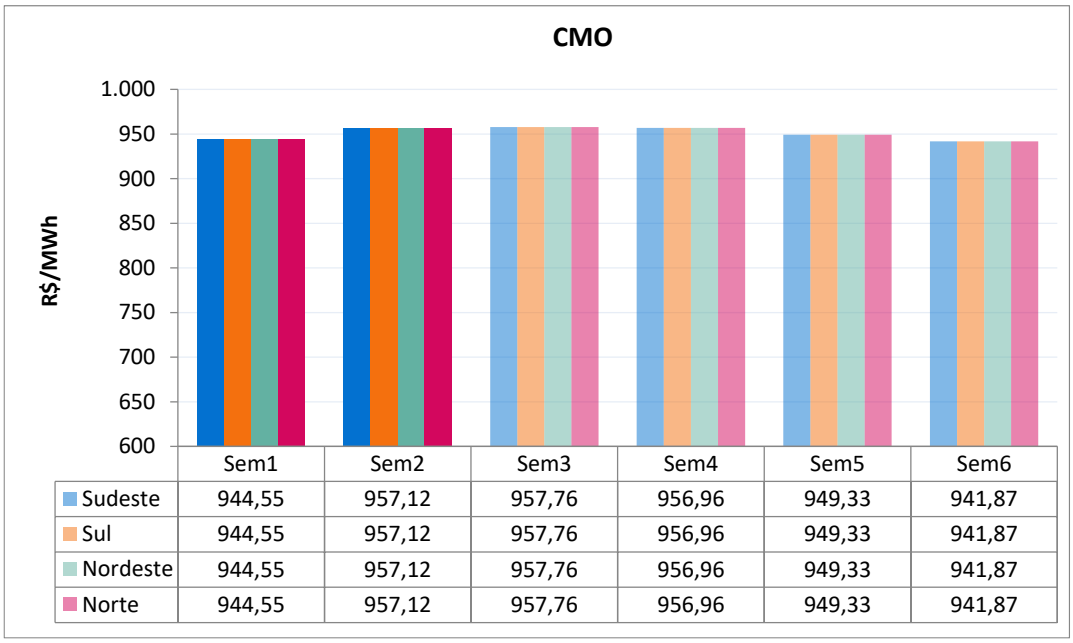

5.2. POLÍTICA DE OPERAÇÃO ENERGÉTICA

Para esta semana operativa, está prevista a seguinte política de intercâmbio de energia entre regiões:

Região SE/CO → Geração minimizada de acordo com os condicionantes hidráulicos.

Região Sul → Geração dimensionada para fechamento do balanço energético do SIN.

Região NE → Aumento da geração eólica e exportação de energia, modulando em função de seus recursos energéticos, respeitando-se os limites elétricos vigentes.

Região Norte → Redução da exploração das disponibilidades energéticas, respeitando-se os limites elétricos vigentes.

O conteúdo desta publicação foi produzido pelo ONS com base em dados e informações de conhecimento público. É de responsabilidade exclusiva dos agentes e demais interessados a obtenção de outros dados e informações, a realização de análises, estudos e avaliações para fins de tomada de decisões, definição de estratégias de atuação, assunção de compromissos e obrigações e quaisquer outras finalidades, em qualquer tempo e sob qualquer condição. É proibida a reprodução ou utilização total ou parcial do presente sem a identificação da fonte.

6. ANÁLISE DA VARIAÇÃO SEMANAL DO CMO

Esta análise visa identificar os principais parâmetros cujas atualizações impactaram os CMO deste PMO, em comparação com os valores obtidos na última revisão.

Foram realizados 8 estudos, onde o caso inicial foi construído com base nos dados oficiais da última revisão deste PMO. Neste primeiro estudo, denominado de "previsão perfeita", a partida dos reservatórios foi estimada conforme indicado para esta semana na última revisão.

O segundo estudo foi realizado com os dados do caso inicial sendo substituída a previsão de vazões.

A partir do conjunto de dados do segundo estudo foram elaborados os demais casos onde foram atualizadas, sequencialmente, as seguintes informações: níveis de partida dos reservatórios, previsão de carga, disponibilidade das usinas térmicas e hidráulicas, restrições de limites de intercâmbio, restrições hidráulicas e, por fim, os demais dados que compõem toda informação referente a atual revisão.

Os custos marginais de operação dos quatro subsistemas que compõem o SIN estão acoplados e são apresentados na Figura 3. Os principais fatores que influenciaram na elevação do CMO dos subsistemas SE/CO, S, NE e N foram as alterações nas disponibilidades das usinas térmicas e hidráulicas e restrições hidráulicas. A atualização dos níveis de partida e da previsão de carga contribuíram no sentido contrário, ou seja, limitaram parcialmente os efeitos das alterações de disponibilidade e restrições.

Figura 3 – Análise da variação do CMO nos subsistemas SE/CO, S, NE e N

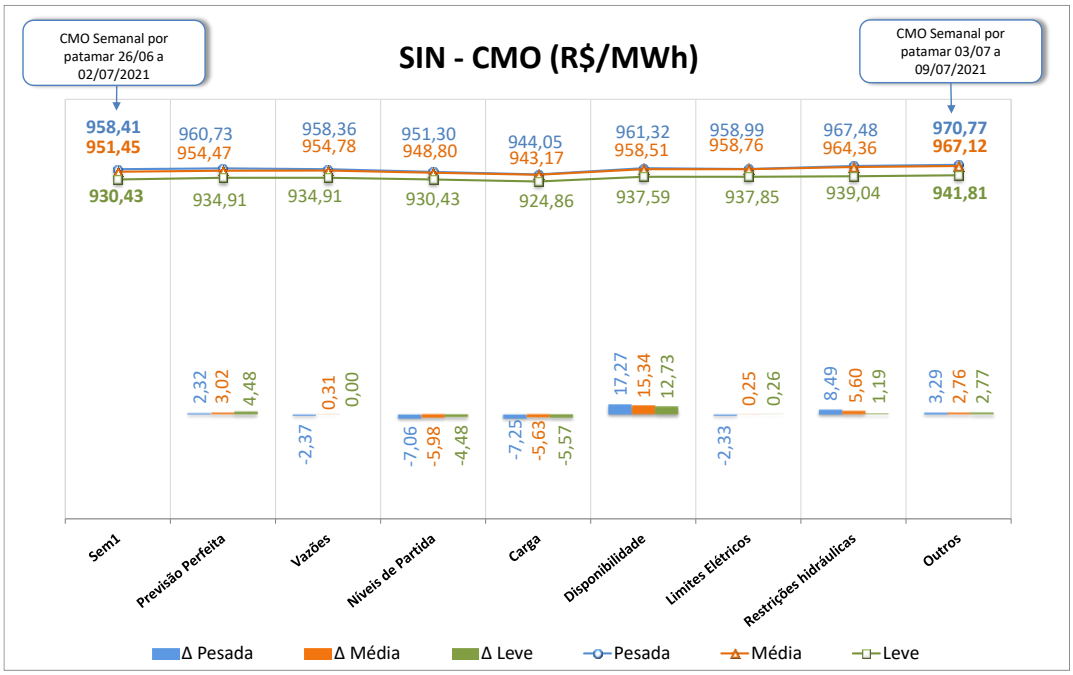

O conteúdo desta publicação foi produzido pelo ONS com base em dados e informações de conhecimento público. É de responsabilidade exclusiva dos agentes e demais interessados a obtenção de outros dados e informações, a realização de análises, estudos e avaliações para fins de tomada de decisões, definição de estratégias de atuação, assunção de compromissos e obrigações e quaisquer outras finalidades, em qualquer tempo e sob qualquer condição. É proibida a reprodução ou utilização total ou parcial do presente sem a identificação da fonte.

7. GERAÇÃO TÉRMICA

A Figura 4 apresenta, para cada subsistema, o despacho térmico por modalidade indicado pelo DECOMP para a próxima semana operativa.

Figura 4 – Geração térmica para a próxima semana operativa

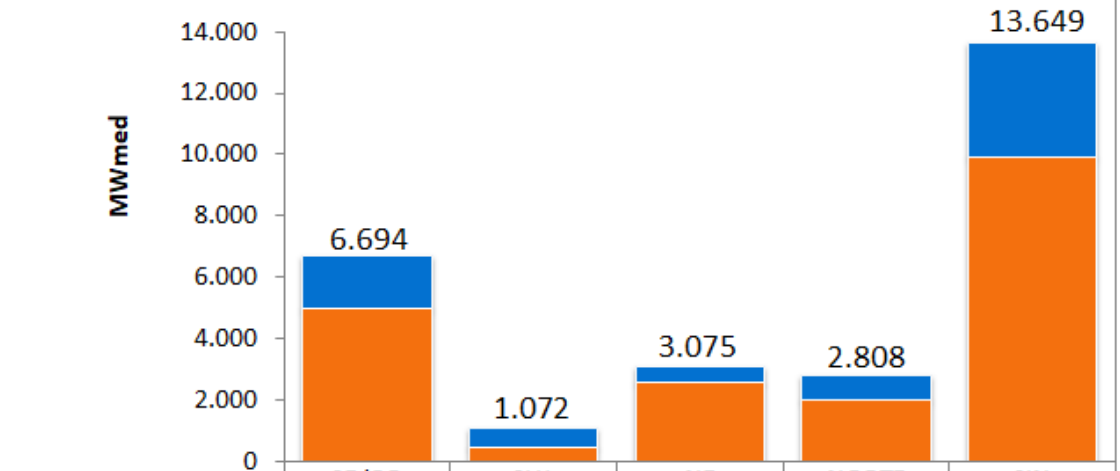

	SE/CO	SUL	NE	NORTE	SIN
RESTRIÇÃO ELÉTRICA	0	0	0	0	0
INFLEXIBILIDADE	1734	634	537	836	3741
ORDEM DE MÉRITO	4960	438	2538	1972	9908

Na tabela abaixo segue a indicação de despacho antecipado por ordem de mérito de custo para a semana de 04/09 a 10/09/2021.

Tabela 4 – UTEs com contrato de combustível GNL

UTE			Benefício (R$/MWh)		
Nome	Cod	CVU (R$/MWh)	Carga Pesada	Carga Média	Carga Leve
SANTA CRUZ	86	199,25	834,99 (1)	834,99 (1)	833,46 (1)
LUIZORMELO	15	303,14	834,99 (1)	834,99 (1)	833,46 (1)
PSERGIPE I	224	304,16	337,36 (1)	337,36 (1)	337,36 (1)

(1) Comandado o despacho antecipado por ordem de mérito de custo nesse patamar

(2) NÃO foi comandado o despacho antecipado por ordem de mérito de custo nesse patamar

Assim sendo, há previsão de despacho antecipado por ordem de mérito de custo para as UTE Santa Cruz, Luiz O. R. Melo e Porto Sergipe I, para a semana de 04/09 a 10/09/2021.

Ressalta-se que, conforme declaração do agente, a UTE Luiz O. R. Melo tem parada programada para o período entre 15/08 e 13/09/2021.

O conteúdo desta publicação foi produzido pelo ONS com base em dados e informações de conhecimento público. É de responsabilidade exclusiva dos agentes e demais interessados a obtenção de outros dados e informações, a realização de análises, estudos e avaliações para fins de tomada de decisões, definição de estratégias de atuação, assunção de compromissos e obrigações e quaisquer outras finalidades, em qualquer tempo e sob qualquer condição. É proibida a reprodução ou utilização total ou parcial do presente sem a identificação da fonte.

8. IMPORTAÇÃO DE ENERGIA DA REPÚBLICA ORIENTAL DO URUGUAI

8.1. República Oriental do Uruguai

Para a próxima semana operativa, foram declaradas as seguintes ofertas de importação de energia da República Oriental do Uruguai para o Sistema Interligado Nacional - SIN através das conversoras de Rivera (70 MW) e Melo (500 MW).

- **Eletrobras**

Tabela 5 – Energia ofertada para importação

	Oferta de Energia para a Semana de 03/07 a 09/07 (MWmed)			
	Bloco 1	Bloco 2	Bloco 3	Total
Carga Pesada	70	90	135	295
Carga Média	70	90	135	295
Carga Leve	70	90	135	295
CVU (R$/MWh)	647,83	1.062,27	1.217,47	

- **Enel**

Conforme declaração do agente, esta importação poderá ser realizada exclusivamente pela conversora Melo.

Tabela 6 – Energia ofertada para importação

	Oferta de Energia para a Semana de 03/07 a 09/07 (MWmed)			
	Bloco 1	Bloco 2	Bloco 3	Total
Carga Pesada	50	90	135	275
Carga Média	50	90	135	275
Carga Leve	50	90	135	275
CVU (R$/MWh)	644,26	1.058,50	1.214,59	

O conteúdo desta publicação foi produzido pelo ONS com base em dados e informações de conhecimento público. É de responsabilidade exclusiva dos agentes e demais interessados a obtenção de outros dados e informações, a realização de análises, estudos e avaliações para fins de tomada de decisões, definição de estratégias de atuação, assunção de compromissos e obrigações e quaisquer outras finalidades, em qualquer tempo e sob qualquer condição. É proibida a reprodução ou utilização total ou parcial do presente sem a identificação da fonte.

8.2. República da Argentina

- **Enel**

Para a próxima semana operativa, foi declarada a seguinte oferta de importação de energia da República da Argentina para o SIN através das conversoras de Garabi 1 (1.100 MW) e Garabi 2 (1.100 MW).

Tabela 7 – Energia ofertada para importação

	Oferta de Energia para a Semana de 03/07 a 09/07 (MWmed)			
	Bloco 1	Bloco 2	Bloco 3	Total
Carga Pesada	300	400	400	1.100
Carga Média	300	400	400	1.100
Carga Leve	300	400	400	1.100
CVU (R$/MWh)	801,14	1.074,89	1.379,70	

Nota: Detalhes sobre a importação de energia vide Portaria Nº 339, de 15 de agosto de 2018 disponível em: http://pesquisa.in.gov.br/imprensa/jsp/visualiza/index.jsp?data=17/08/2018&jornal=515&pagina=60&totalArquivos=136

O conteúdo desta publicação foi produzido pelo ONS com base em dados e informações de conhecimento público. É de responsabilidade exclusiva dos agentes e demais interessados a obtenção de outros dados e informações, a realização de análises, estudos e avaliações para fins de tomada de decisões, definição de estratégias de atuação, assunção de compromissos e obrigações e quaisquer outras finalidades, em qualquer tempo e sob qualquer condição. É proibida a reprodução ou utilização total ou parcial do presente sem a identificação da fonte.

9. ARMAZENAMENTOS OPERATIVOS

Para uma melhor avaliação de diversos cenários hidrometeorológicos, notadamente, aqueles de curto prazo e suas influências nas previsões de vazões nos subsistemas, os resultados desta revisão do PMO contemplam cenários de afluências visando melhor representar a ocorrência de precipitação e, consequentemente, seus efeitos sobre as afluências e armazenamentos.

Além dos resultados associados ao valor esperado das previsões de afluências, as simulações operativas também foram realizadas com os limites superior e inferior das previsões de afluências. Apresentamos a seguir os resultados obtidos com a aplicação dos diferentes cenários de afluência.

Tabela 8 – Previsão de ENA dos cenários de sensibilidade

Subsistema	ENERGIAS NATURAIS AFLUENTES					
	Previsão Mensal					
	LI		VE		LS	
	(MWmed)	%MLT	(MWmed)	%MLT	(MWmed)	%MLT
SE/CO	14.212	**55**	16.052	**62**	17.888	**70**
Sul	3.725	**34**	6.210	**57**	9.340	**85**
Nordeste	1.515	**40**	1.606	**42**	1.704	**45**
Norte	3.803	**72**	4.144	**79**	4.485	**85**

Tabela 9 – Previsão de %EARmáx para o final do mês

Subsistema	% EARmáx 02/07	% EARmáx - 31/07		
	NÍVEL INICIAL	NÍVEL PMO		
	VE	LI	VE	LS
SE/CO	28,8	25,5	26,4	27,1
Sul	64,4	42,0	46,5	51,3
Nordeste	59,2	53,5	53,8	53,6
Norte	82,8	79,6	79,9	80,3

O conteúdo desta publicação foi produzido pelo ONS com base em dados e informações de conhecimento público. É de responsabilidade exclusiva dos agentes e demais interessados a obtenção de outros dados e informações, a realização de análises, estudos e avaliações para fins de tomada de decisões, definição de estratégias de atuação, assunção de compromissos e obrigações e quaisquer outras finalidades, em qualquer tempo e sob qualquer condição. É proibida a reprodução ou utilização total ou parcial do presente sem a identificação da fonte.

10. RESERVATÓRIOS EQUIVALENTES DE ENERGIA

A seguir são apresentadas as previsões de Energia Natural Afluente para a próxima semana operativa e para o mês de julho, bem como as previsões de Energia Armazenada nos Reservatórios Equivalentes de Energia – REE, desta revisão do PMO.

Tabela 10 – Previsão de ENA por REE

Valor Esperado das Energias Naturais Afluentes				
REE	Previsão Semanal		Previsão Mensal	
	03/07/2021 a 09/07/2021		jul-21	
	(MWmed)	%MLT	(MWmed)	%MLT
Sudeste	1.881	65	1.827	63
Madeira	4.420	114	3.660	95
Teles Pires	902	92	810	82
Itaipu	2.060	66	2.050	66
Paraná	6.800	54	6.528	52
Paranapanema	1.034	45	1.053	46
Sul	3.912	66	3.865	65
Iguaçu	2.861	57	2.345	47
Nordeste	1.633	43	1.606	42
Norte	1.965	76	1.741	67
Belo Monte	1.661	102	1.267	78
Manaus	1.393	131	1.273	120

Tabela 11 – Previsão de %EARmáx por REE

% Energia Armazenável Máxima		
REE	Previsão Semanal	Previsão Mensal
	09-jul	31-jul
	(%EARmáx)	(%EARmáx)
Sudeste	37,6	34,5
Madeira	84,4	76,9
Teles Pires	65,1	58,3
Itaipu	15,3	57,7
Paraná	23,6	21,9
Paranapanema	39,9	41,0
Sul	62,6	49,3
Iguaçu	62,8	44,0
Nordeste	57,7	53,8
Norte	82,1	79,7
Belo Monte	100,0	98,6
Manaus	92,3	80,9

O conteúdo desta publicação foi produzido pelo ONS com base em dados e informações de conhecimento público. É de responsabilidade exclusiva dos agentes e demais interessados a obtenção de outros dados e informações, a realização de análises, estudos e avaliações para fins de tomada de decisões, definição de estratégias de atuação, assunção de compromissos e obrigações e quaisquer outras finalidades, em qualquer tempo e sob qualquer condição. É proibida a reprodução ou utilização total ou parcial do presente sem a identificação da fonte.

11. DESPACHO TÉRMICO POR MODALIDADE, PATAMAR DE CARGA E USINA

Nas tabelas abaixo, a diferenciação entre geração por inflexibilidade e por ordem de mérito tem caráter informativo, com o objetivo de detalhar a informação de inflexibilidade enviada pelos respectivos agentes para esta revisão do PMO. Ressalta-se que nas etapas de Programação Diária e Tempo Real, o montante despachado nas usinas termelétricas indicadas por ordem de mérito é plenamente intitulado como ordem de mérito.

REGIÃO SUDESTE/CENTRO-OESTE

Térmicas Potência (MW)	Combustível	CVU (R$/MWh)	Inflexibilidade			Ordem de Mérito			Total Mérito e INFL.			Razão Elétrica			Total UTE		
			P	M	L	P	M	L	P	M	L	P	M	L	P	M	L
ATLAN_CSA (255)	Resíduos	0,00	156,0	156,0	156,0				156,0	156,0	156,0				156,0	156,0	156,0
ANGRA 2 (1350)	Nuclear	20,12				0,0	0,0	0,0	0,0	0,0	0,0				0,0	0,0	0,0
ANGRA 1 (640)	Nuclear	31,17	640,0	640,0	640,0	0,0	0,0	0,0	640,0	640,0	640,0				640,0	640,0	640,0
NORTEFLU 1 (400)	Gás	82,94	400,0	400,0	400,0	0,0	0,0	0,0	400,0	400,0	400,0				400,0	400,0	400,0
NORTEFLU 2 (100)	Gás	95,16	100,0	100,0	100,0	0,0	0,0	0,0	100,0	100,0	100,0				100,0	100,0	100,0
O.PINTADA (50)	Biomassa	112,47	5,0	5,0	5,0	45,0	45,0	45,0	50,0	50,0	50,0				50,0	50,0	50,0
UTE STA VI (41)	Biomassa	121,49	13,0	13,0	13,0	28,4	28,4	28,4	41,4	41,4	41,4				41,4	41,4	41,4
PREDILECTA (5)	Biomassa	158,95	1,0	1,0	1,0	4,0	4,0	4,0	5,0	5,0	5,0				5,0	5,0	5,0
NORTEFLU 3 (200)	Gás	180,48	200,0	200,0	200,0	0,0	0,0	0,0	200,0	200,0	200,0				200,0	200,0	200,0
BAIXADA FL (530)	Gás	196,19				530,0	530,0	530,0	530,0	530,0	530,0				530,0	530,0	530,0
SANTA CRUZ (500)	GNL	199,25				350,0	350,0	350,0	350,0	350,0	350,0				350,0	350,0	350,0
ATLANTICO (235)	Resíduos	202,37	218,7	218,7	218,7	0,0	0,0	0,0	218,7	218,7	218,7				218,7	218,7	218,7
T.LAGOAS (350)	Gás	262,50				270,0	270,0	270,0	270,0	270,0	270,0				270,0	270,0	270,0
JUIZ DE FO (87)	Gás	283,74				80,6	80,6	80,6	80,6	80,6	80,6				80,6	80,6	80,6
LUIZORMELO (204)	GNL	303,14				204,0	204,0	204,0	204,0	204,0	204,0				204,0	204,0	204,0
ST.CRUZ 34 (436)	Óleo	310,41															
TERMORIO (1036)	Gás	329,49				850,0	850,0	850,0	850,0	850,0	850,0				850,0	850,0	850,0
CUBATAO (216)	Gás	350,13				209,0	209,0	209,0	209,0	209,0	209,0				209,0	209,0	209,0
SEROPEDICA (386)	Gás	410,56				360,0	360,0	360,0	360,0	360,0	360,0				360,0	360,0	360,0
PIRAT.12 O (200)	Gás	470,34															
NPIRATINGA (572)	Gás	548,04				265,0	265,0	265,0	265,0	265,0	265,0				265,0	265,0	265,0
IBIRITE (226)	Gás	573,90				222,0	222,0	222,0	222,0	222,0	222,0				222,0	222,0	222,0
NORTEFLU 4 (127)	Gás	600,80				126,0	126,0	126,0	126,0	126,0	126,0				126,0	126,0	126,0
CUIABA CC (529)	Gás	701,88				490,0	490,0	490,0	490,0	490,0	490,0				490,0	490,0	490,0
T.MACAE (929)	Gás	738,49				751,0	751,0	751,0	751,0	751,0	751,0				751,0	751,0	751,0
PALMEIR_GO (176)	Diesel	762,95				0,0	0,0	0,0	0,0	0,0	0,0				0,0	0,0	0,0
TNORTE 2 (340)	Óleo	910,86				0,0	0,0	0,0	0,0	0,0	0,0				0,0	0,0	0,0
VIANA (175)	Óleo	930,45				174,6	174,6	174,6	174,6	174,6	174,6				174,6	174,6	174,6
CAMPOS (25)	Gás	978,10															
DAIA (44)	Diesel	1019,32															
GOIANIA 2 (140)	Diesel	1066,14															
XAVANTES (54)	Diesel	1464,89															
TOTAL SE/CO (10558)			1733,7	1733,7	1733,7	4959,6	4959,6	4959,6	6693,3	6693,3	6693,3	0,0	0,0	0,0	6693,3	6693,3	6693,3

REGIÃO SUL

Térmicas Potência (MW)	Combustível	CVU (R$/MWh)	Inflexibilidade			Ordem de Mérito			Total Mérito e INFL.			Razão Elétrica			Total UTE		
			P	M	L	P	M	L	P	M	L	P	M	L	P	M	L
URUGUAIANA (640)	Gás	0,00															
PAMPA SUL (345)	Carvão	69,75				0,0	0,0	0,0	0,0	0,0	0,0				0,0	0,0	0,0
SAO SEPE (8)	Biomassa	87,75	7,0	7,0	7,0	0,0	0,0	0,0	7,0	7,0	7,0				7,0	7,0	7,0
CANDIOTA_3 (350)	Carvão	90,73	325,0	325,0	325,0	0,0	0,0	0,0	325,0	325,0	325,0				325,0	325,0	325,0
J.LACER. C (363)	Carvão	206,84				0,0	0,0	0,0	0,0	0,0	0,0				0,0	0,0	0,0
J.LACER. B (262)	Carvão	244,14	160,0	160,0	160,0	102,0	102,0	102,0	262,0	262,0	262,0				262,0	262,0	262,0
J.LAC. A2 (132)	Carvão	245,21	70,0	70,0	70,0	62,0	62,0	62,0	132,0	132,0	132,0				132,0	132,0	132,0
J.LAC. A1 (100)	Carvão	270,48	70,0	70,0	70,0	30,0	30,0	29,8	100,0	100,0	99,8				100,0	100,0	99,8
MADEIRA (4)	Biomassa	321,94	2,0	2,0	2,0	1,0	1,0	1,0	3,0	3,0	3,0				3,0	3,0	3,0
FIGUEIRA (20)	Carvão	475,68				0,0	0,0	0,0	0,0	0,0	0,0				0,0	0,0	0,0
CANOAS (249)	Diesel	698,14				243,1	243,1	243,1	243,1	243,1	243,1				243,1	243,1	243,1
ARAUCARIA (484)	Gás	1138,07															
TOTAL SUL (2957)			634,0	634,0	634,0	438,1	438,1	437,9	1072,1	1072,1	1071,9	0,0	0,0	0,0	1072,1	1072,1	1071,9

O conteúdo desta publicação foi produzido pelo ONS com base em dados e informações de conhecimento público. É de responsabilidade exclusiva dos agentes e demais interessados a obtenção de outros dados e informações, a realização de análises, estudos e avaliações para fins de tomada de decisões, definição de estratégias de atuação, assunção de compromissos e obrigações e quaisquer outras finalidades, em qualquer tempo e sob qualquer condição. É proibida a reprodução ou utilização total ou parcial do presente sem a identificação da fonte.

REGIÃO NORDESTE

Térmicas Potência (MW)	Combustível	CVU (R$/MWh)	Inflexibilidade			Ordem de Mérito			Total Mérito e INFL.			Razão Elétrica			Total UTE		
			P	M	L	P	M	L	P	M	L	P	M	L	P	M	L
ALTOS (13)	Diesel	0,00															
ARACATI (11)	Diesel	0,00															
BATURITE (11)	Diesel	0,00															
C.MAIOR (13)	Diesel	0,00															
CAUCAIA (15)	Diesel	0,00															
CRATO (13)	Diesel	0,00															
IGUATU (15)	Diesel	0,00															
JUAZEIRO N (15)	Diesel	0,00															
MARAMBAIA (13)	Diesel	0,00															
NAZARIA (13)	Diesel	0,00															
PECEM (15)	Diesel	0,00															
ERB CANDEI (17)	Biomassa	87,81	4,5	4,5	4,5	6,5	6,5	6,5	11,0	11,0	11,0				11,0	11,0	11,0
PROSPERIDA (28)	Gás	165,61				28,0	28,0	28,0	28,0	28,0	28,0				28,0	28,0	28,0
TERMOPE (533)	Gás	173,38	532,7	532,7	532,7	0,0	0,0	0,0	532,7	532,7	532,7				532,7	532,7	532,7
FORTALEZA (327)	Gás	245,46				326,6	326,6	326,6	326,6	326,6	326,6				326,6	326,6	326,6
P.PECEM1 (720)	Carvão	265,17				720,0	720,0	720,0	720,0	720,0	720,0				720,0	720,0	720,0
P.PECEM2 (365)	Carvão	271,10				365,0	365,0	365,0	365,0	365,0	365,0				365,0	365,0	365,0
PSERGIPE I (1516)	GNL	304,16															
TERMOCEARA (223)	Gás	431,13				0,0	0,0	0,0	0,0	0,0	0,0				0,0	0,0	0,0
SYKUE I (30)	Biomassa	510,12				0,0	0,0	0,0	0,0	0,0	0,0				0,0	0,0	0,0
VALE ACU (368)	Gás	618,70				110,0	110,0	110,0	110,0	110,0	110,0				110,0	110,0	110,0
T.BAHIA (186)	Gás	633,56				158,9	158,9	158,9	158,9	158,9	158,9				158,9	158,9	158,9
PERNAMBU_3 (201)	Óleo	802,20				0,0	0,0	0,0	0,0	0,0	0,0				0,0	0,0	0,0
BAHIA_1 (31)	Óleo	818,43				27,0	27,0	27,0	27,0	27,0	27,0				27,0	27,0	27,0
MARACANAU (168)	Óleo	905,02				121,0	118,5	115,6	121,0	118,5	115,6				121,0	118,5	115,6
TERMOCABO (50)	Óleo	919,04				49,7	49,7	49,7	49,7	49,7	49,7				49,7	49,7	49,7
TERMONE (171)	Óleo	922,48				158,0	158,0	158,0	158,0	158,0	158,0				158,0	158,0	158,0
TERMOPB (171)	Óleo	922,48				154,0	154,0	154,0	154,0	154,0	154,0				154,0	154,0	154,0
CAMPINA_GR (169)	Óleo	930,47				118,0	118,0	118,0	118,0	118,0	118,0				118,0	118,0	118,0
SUAPE II (381)	Óleo	951,30				358,4	358,4		358,4	358,4					358,4	358,4	0,0
POTIGUAR_3 (66)	Diesel	1002,56															
POTIGUAR (53)	Diesel	1002,57															
AREMBEPE (150)	Óleo	1021,36															
MURICY (147)	Óleo	1021,36															
GLOBAL I (149)	Óleo	1054,22															
GLOBAL II (149)	Óleo	1054,22															
PETROLINA (136)	Óleo	1120,20															
PAU FERRO (94)	Diesel	1135,00															
TERMOMANAU (143)	Diesel	1135,00															
TOTAL NE (6889)			537,2	537,2	537,2	2701,1	2698,6	2337,3	3238,3	3235,8	2874,5	0,0	0,0	0,0	3238,3	3235,8	2874,5

REGIÃO NORTE

Térmicas Potência (MW)	Combustível	CVU (R$/MWh)	Inflexibilidade			Ordem de Mérito			Total Mérito e INFL.			Razão Elétrica			Total UTE		
			P	M	L	P	M	L	P	M	L	P	M	L	P	M	L
C. ROCHA (85)	Gás	0,00	65,0	65,0	65,0				65,0	65,0	65,0				65,0	65,0	65,0
JARAQUI (75)	Gás	0,00	63,0	63,0	63,0				63,0	63,0	63,0				63,0	63,0	63,0
MANAUARA (67)	Gás	0,00	64,5	64,5	64,5				64,5	64,5	64,5				64,5	64,5	64,5
PONTA NEGR (66)	Gás	0,00	64,0	64,0	64,0				64,0	64,0	64,0				64,0	64,0	64,0
TAMBAQUI (93)	Gás	0,00	63,0	63,0	63,0				63,0	63,0	63,0				63,0	63,0	63,0
MARANHAO3 (519)	Gás	85,72	180,8	184,8	171,2	0,0	0,0	0,0	180,8	184,8	171,2				180,8	184,8	171,2
APARECIDA (166)	Gás	96,11	75,0	75,0	75,0	71,0	71,0	71,0	146,0	146,0	146,0				146,0	146,0	146,0
UTE MAUA 3 (591)	Gás	96,11	264,0	264,0	264,0	326,8	326,8	326,8	590,8	590,8	590,8				590,8	590,8	590,8
PARNAIB_IV (56)	Gás	151,69				56,3	56,3	56,3	56,3	56,3	56,3				56,3	56,3	56,3
MARAN_VL_7 (336)	Gás	183,95				326,0	334,9	333,8	326,0	334,9	333,8				326,0	334,9	333,8
MARANIVL_7 (336)	Gás	183,95				325,9	334,9	333,7	325,9	334,9	333,7				325,9	334,9	333,7
MARAN_VL22 (1)	Gás	183,96				1,1	1,1	1,1	1,1	1,1	1,1				1,1	1,1	1,1
MARANIVL22 (1)	Gás	183,96				1,1	1,1	1,1	1,1	1,1	1,1				1,1	1,1	1,1
N.VEN2_L22 (27)	Gás	232,27				27,0	27,0	27,0	27,0	27,0	27,0				27,0	27,0	27,0
N.VEN2_L7 (151)	Gás	232,27				144,4	150,2	149,4	144,4	150,2	149,4				144,4	150,2	149,4
P. ITAQUI (360)	Carvão	264,93				360,1	360,1	360,1	360,1	360,1	360,1				360,1	360,1	360,1
GERAMAR1 (166)	Óleo	930,43				159,2	159,2	159,2	159,2	159,2	159,2				159,2	159,2	159,2
GERAMAR2 (166)	Óleo	930,43				159,2	159,2	159,2	159,2	159,2	159,2				159,2	159,2	159,2
TOTAL NORTE (3264)			839,3	843,3	829,7	1958,1	1981,8	1978,7	2797,4	2825,1	2808,4	0,0	0,0	0,0	2797,4	2825,1	2808,4

O conteúdo desta publicação foi produzido pelo ONS com base em dados e informações de conhecimento público. É de responsabilidade exclusiva dos agentes e demais interessados a obtenção de outros dados e informações, a realização de análises, estudos e avaliações para fins de tomada de decisões, definição de estratégias de atuação, assunção de compromissos e obrigações e quaisquer outras finalidades, em qualquer tempo e sob qualquer condição. É proibida a reprodução ou utilização total ou parcial do presente sem a identificação da fonte.