1. APRESENTAÇÃO

Na semana de 28/08 a 03/09/2021 houve precipitação nas bacias dos rios Paranapanema e Tietê, e na incremental a UHE Itaipu. Nas demais bacias hidrográficas de interesse do SIN permaneceu a estiagem.

Na semana de 04/09 a 10/09/2021 deve ocorrer precipitação significativa nas bacias dos rios Jacuí e Uruguai, e chuva fraca na bacia do rio Iguaçu.

Para a semana operativa de 04/09 a 10/09/2021, houve oferta de energia da República Oriental do Uruguai e da República da Argentina. De acordo com o Art. 2º da Portaria MME nº 339, de 15 de agosto de 2018, as ofertas para importação de energia não foram consideradas na elaboração do PMO.

Os valores médios semanais do Custo Marginal de Operação – CMO dos subsistemas do SIN sofreram as seguintes alterações em relação à semana anterior:

- SE/CO: de R$ 1.027,43/MWh para R$ 1.261,35/MWh
- Sul: de R$ 1.027,43/MWh para R$ 1.261,35/MWh
- Nordeste: de R$ 996,06/MWh para R$ 968,77/MWh
- Norte: de R$ 1.027,43/MWh para R$ 1.261,35/MWh

Desde o dia 01/01/2020, o despacho por ordem de mérito é indicado diariamente pelos resultados do modelo DESSEM. Assim, o despacho por ordem de mérito semanal, conforme publicado nesse documento, tem caráter apenas informativo. Da mesma forma, desde o dia 01/01/2021, a formação de preço deixou o formato semanal/patamar de carga e passou a ser horário, de acordo também com os resultados do modelo DESSEM.

2. NOTÍCIAS

Nos dias 23 e 24 de setembro será realizada a reunião de elaboração do PMO de Outubro de 2021, com transmissão ao vivo através do site do ONS.

Como medida adicional de prevenção ao Coronavírus, o ONS informa que está suspensa, temporariamente, a participação presencial nas reuniões.

3. ANÁLISE DAS CONDIÇÕES HIDROMETEOROLÓGICAS

3.1. PREVISÃO PARA A PRÓXIMA SEMANA

A atuação de áreas de instabilidade no início da semana e a passagem de uma frente fria pela região Sul ocasiona totais significativos de precipitação nas bacias dos rios Jacuí e Uruguai, e, chuva fraca na bacia do rio Iguaçu (Figura 1).

O conteúdo desta publicação foi produzido pelo ONS com base em dados e informações de conhecimento público. É de responsabilidade exclusiva dos agentes e demais interessados a obtenção de outros dados e informações, a realização de análises, estudos e avaliações para fins de tomada de decisões, definição de estratégias de atuação, assunção de compromissos e obrigações e quaisquer outras finalidades, em qualquer tempo e sob qualquer condição. É proibida a reprodução ou utilização total ou parcial do presente sem a identificação da fonte.

Figura 1 - Precipitação acumulada prevista pelo modelo ECMWF (ECMWF) para o período de 04/09/2021 a 12/09/2021.

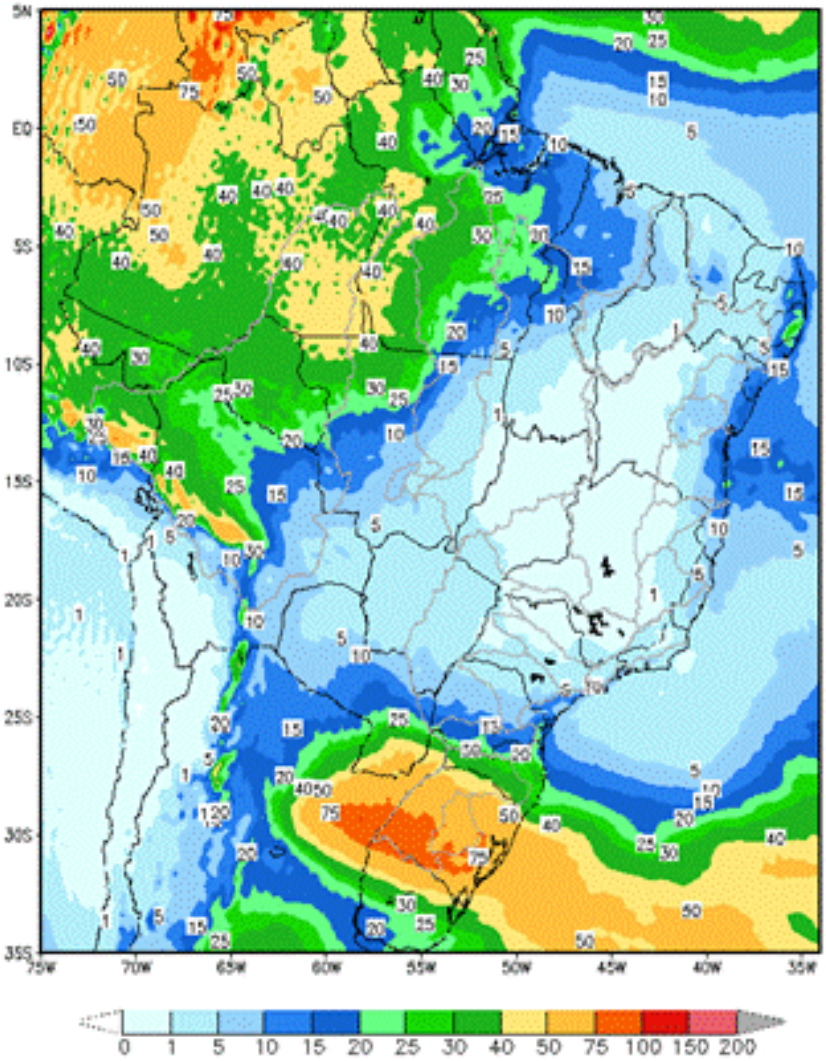

Em comparação com os valores estimados para a semana em curso, prevê-se para a próxima semana operativa recessão nas afluências dos subsistemas Sudeste/Centro-Oeste e Norte, ascensão nas afluências do subsistema Sul e estabilidade nas afluências do Nordeste. A previsão mensal para setembro indica a ocorrência de afluências abaixo da média histórica para todos os subsistemas.

Tabela 1 – Previsão de ENAs da Revisão 1 de Setembro/2021

Revisão 1 do PMO de Setembro/2021 - ENAs previstas				
Subsistema	04/09 a 10/09/2021		Mês de setembro	
	MWmed	%MLT	MWmed	MWmed
SE/CO	10.566	54	SE/CO	10.566
S	3.483	30	S	3.483
NE	1.390	47	NE	1.390
N	1.864	81	N	1.864

O conteúdo desta publicação foi produzido pelo ONS com base em dados e informações de conhecimento público. É de responsabilidade exclusiva dos agentes e demais interessados a obtenção de outros dados e informações, a realização de análises, estudos e avaliações para fins de tomada de decisões, definição de estratégias de atuação, assunção de compromissos e obrigações e quaisquer outras finalidades, em qualquer tempo e sob qualquer condição. É proibida a reprodução ou utilização total ou parcial do presente sem a identificação da fonte.

4. PREVISÃO DE CARGA

As projeções de carga para o mês de setembro/21 levaram em consideração a progressiva melhora do setor de comércio e serviços do país, e a manutenção da produção Industrial em patamares elevados, apesar dos gargalos associados a escassez de insumos recentemente agravada por problemas de logísticas nos mercados internacionais e aumento da energia elétrica. Ressalta-se que as projeções foram ajustadas em função da expectativa de redução de consumo em virtude da nova bandeira tarifária.

Para a próxima semana operativa as sinalizações meteorológicas indicam para as capitais do subsistema Sudeste/Centro-Oeste temperaturas elevadas e superiores às verificadas na semana em curso, período marcado por temperaturas amenas no Rio de Janeiro e São Paulo, enquanto nas capitais do Centro-Oeste foram observadas temperaturas mais elevadas.

No subsistema Sul, a semana vigente foi marcada pela ocorrência de temperaturas amenas e típicas para essa época do ano, exceto em Porto Alegre onde foram observadas temperaturas elevadas. Para a próxima semana as previsões sinalizam comportamentos distintos para as capitais desse subsistema. Para Porto Alegre existe expectativa de redução das temperaturas máximas, enquanto para Curitiba há indicação de temperaturas superiores às verificadas na semana atual, por fim, para Florianópolis existe a expectativa de manutenção do comportamento observado nessa semana.

Nas capitais dos subsistemas Nordeste e Norte são esperadas condições meteorológicas estáveis em relação às últimas semanas, seguindo o comportamento típico para essa época do ano, com destaque para Manaus e Belém onde existe expectativa de precipitação durante todos os dias da próxima semana operativa.

Para o mês de setembro são previstas taxas de crescimento de 3,2% para o subsistema Nordeste, 3,1% no subsistema Norte e decréscimos de 1,6% e 0,1% para os subsistemas Sudeste/Centro-Oeste e Sul, respectivamente.

Tabela 2 – Evolução da carga do PMO de Setembro 2021

Subsistema	CARGA SEMANAL (MWmed)					CARGA MENSAL (MWmed)	
	1ª Sem	2ª Sem	3ª Sem	4ª Sem	5ª Sem	set/21	Var. (%) set/21 -> set/20
SE/CO	38.868	38.631	40.806	40.864	40.930	40.143	-1,6%
Sul	11.380	11.070	11.547	11.614	11.679	11.461	-0,1%
Nordeste	11.261	11.066	11.477	11.487	11.500	11.367	3,2%
Norte	6.310	6.060	6.195	6.223	6.232	6.189	3,1%
SIN	**67.819**	**66.827**	**70.025**	**70.188**	**70.341**	**69.160**	**-0,2%**

O conteúdo desta publicação foi produzido pelo ONS com base em dados e informações de conhecimento público. É de responsabilidade exclusiva dos agentes e demais interessados a obtenção de outros dados e informações, a realização de análises, estudos e avaliações para fins de tomada de decisões, definição de estratégias de atuação, assunção de compromissos e obrigações e quaisquer outras finalidades, em qualquer tempo e sob qualquer condição. É proibida a reprodução ou utilização total ou parcial do presente sem a identificação da fonte.

5. PRINCIPAIS RESULTADOS

5.1. CUSTO MARGINAL DE OPERAÇÃO (CMO)

A tabela a seguir apresenta o CMO, por subsistema e patamar de carga para próxima semana operativa.

Tabela 3 – CMO por patamar de carga

Patamares de Carga	CMO (R$/MWh)			
	SE/CO	S	NE	N
Pesada	1.286,25	1.286,25	1.007,37	1.286,24
Média	1.283,93	1.283,93	960,30	1.283,93
Leve	1.241,69	1.241,69	955,30	1.241,69
Média Semanal	1.261,35	1.261,35	968,77	1.261,35

Na figura a seguir é apresentada a evolução do CMO médio semanal ao longo deste PMO.

Figura 2 – Evolução semanal do CMO

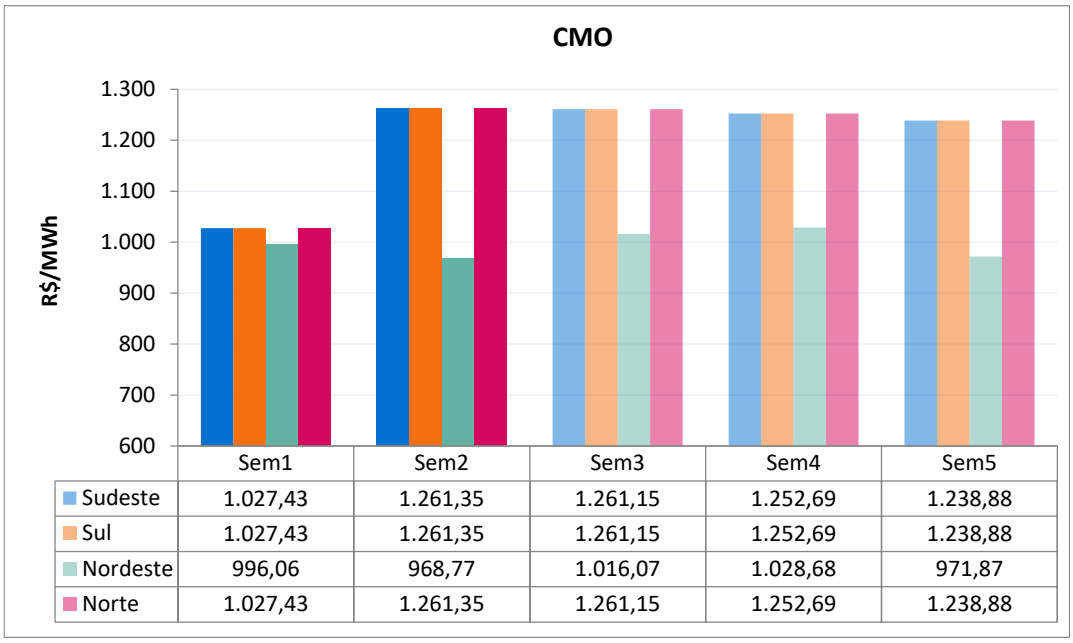

5.2. POLÍTICA DE OPERAÇÃO ENERGÉTICA

Para esta semana operativa, está prevista a seguinte política de intercâmbio de energia entre regiões:

Região SE/CO → Geração minimizada, onde possível, e dimensionada para fechamento do balanço energético do SIN.

Região Sul → Geração dimensionada para fechamento do balanço energético do SIN.

Região NE → Aumento da geração eólica e exportação de energia, modulando em função de seus recursos energéticos, respeitando-se os limites elétricos vigentes.

Região Norte → Redução da exploração das disponibilidades energéticas, respeitando-se os limites elétricos vigentes.

O conteúdo desta publicação foi produzido pelo ONS com base em dados e informações de conhecimento público. É de responsabilidade exclusiva dos agentes e demais interessados a obtenção de outros dados e informações, a realização de análises, estudos e avaliações para fins de tomada de decisões, definição de estratégias de atuação, assunção de compromissos e obrigações e quaisquer outras finalidades, em qualquer tempo e sob qualquer condição. É proibida a reprodução ou utilização total ou parcial do presente sem a identificação da fonte.

6. ANÁLISE DA VARIAÇÃO SEMANAL DO CMO

Esta análise visa identificar os principais parâmetros cujas atualizações impactaram os CMO deste PMO, em comparação com os valores obtidos na última revisão.

Foram realizados 8 estudos, onde o caso inicial foi construído com base nos dados oficiais da última revisão deste PMO. Neste primeiro estudo, denominado de "previsão perfeita", a partida dos reservatórios foi estimada conforme indicado para esta semana na última revisão.

O segundo estudo foi realizado com os dados do caso inicial sendo substituída a previsão de vazões.

A partir do conjunto de dados do segundo estudo foram elaborados os demais casos em que foram atualizadas, sequencialmente, as seguintes informações: níveis de partida dos reservatórios, previsão de carga, disponibilidade das usinas térmicas e hidráulicas, restrições de limites de intercâmbio, restrições hidráulicas e, por fim, os demais dados que compõem toda informação referente a atual revisão.

Os custos marginais de operação dos subsistemas Sudeste/Centro-Oeste, Sul e Norte estão acoplados e são apresentados na Figura 3. O principal fator que influenciou na elevação do CMO destes subsistemas foi a atualização da previsão de vazões. Alterações nas disponibilidades das usinas térmicas e hidráulicas e nas restrições hidráulicas também foram fatores cujas atualizações elevaram o CMO. A atualização dos níveis de partida e previsão de carga e contribuíram no sentido contrário, reduzindo parcialmente a tendência de elevação do CMO.

Figura 3 – Análise da variação do CMO nos subsistemas SE/CO, S e N

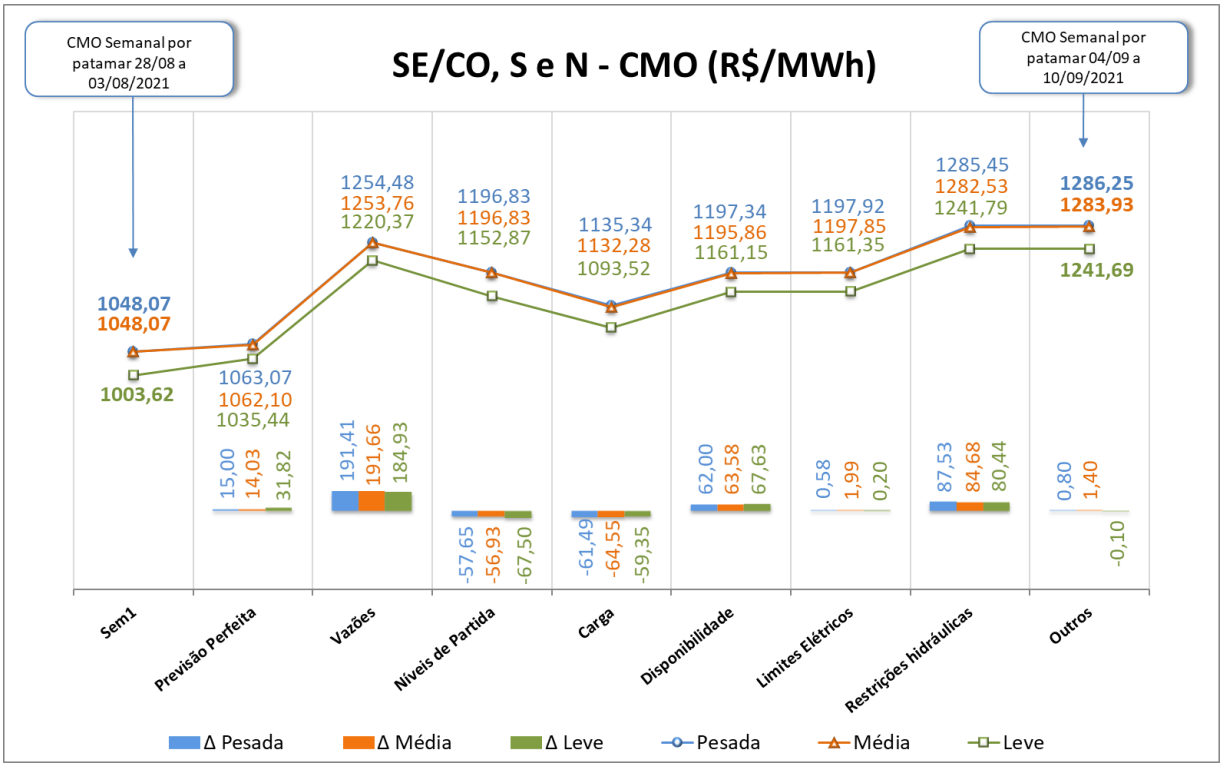

O conteúdo desta publicação foi produzido pelo ONS com base em dados e informações de conhecimento público. É de responsabilidade exclusiva dos agentes e demais interessados a obtenção de outros dados e informações, a realização de análises, estudos e avaliações para fins de tomada de decisões, definição de estratégias de atuação, assunção de compromissos e obrigações e quaisquer outras finalidades, em qualquer tempo e sob qualquer condição. É proibida a reprodução ou utilização total ou parcial do presente sem a identificação da fonte.

O subsistema Nordeste permanece desacoplado das demais regiões devido ao atingimento dos limites de transmissão de exportação de energia para os demais subsistemas. A figura a seguir apresenta variação do CMO do subsistema Nordeste, onde observa-se a estabilidade dos valores em relação aos resultados obtidos na semana 1 do PMO de Setembro/21.

Figura 4 – Análise da variação do CMO no subsistema Nordeste

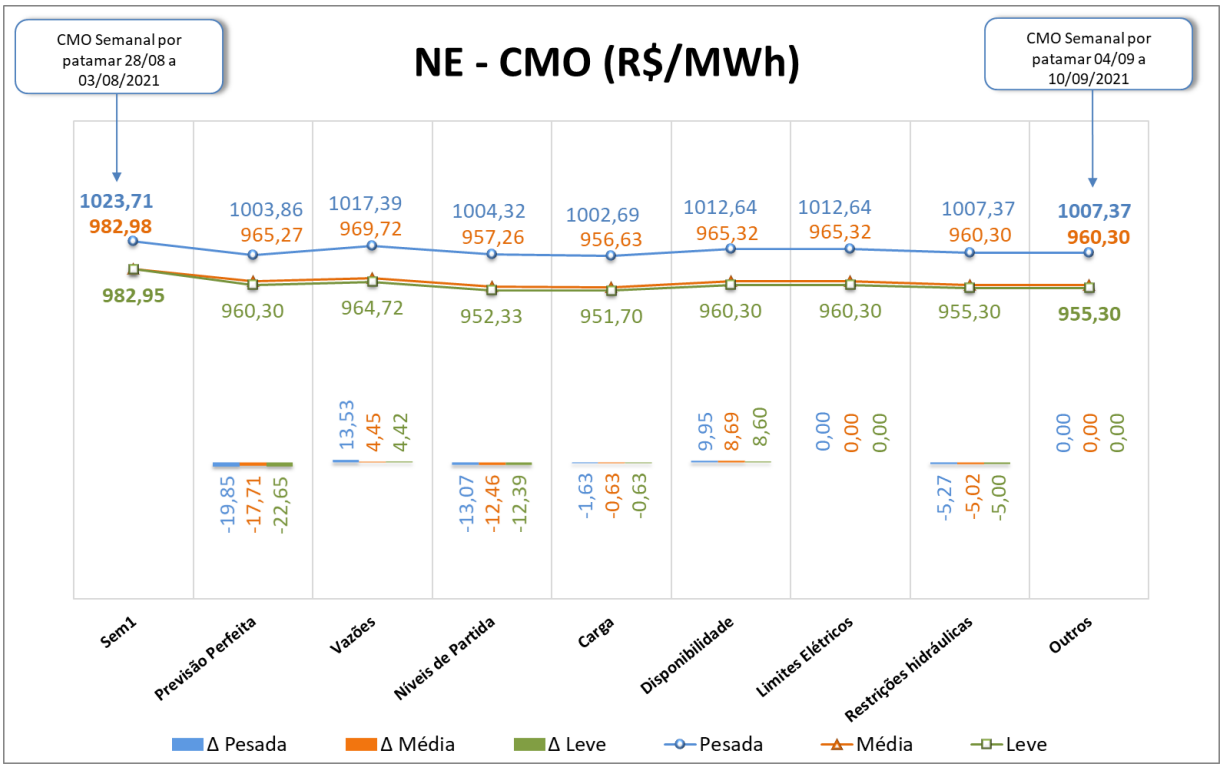

O conteúdo desta publicação foi produzido pelo ONS com base em dados e informações de conhecimento público. É de responsabilidade exclusiva dos agentes e demais interessados a obtenção de outros dados e informações, a realização de análises, estudos e avaliações para fins de tomada de decisões, definição de estratégias de atuação, assunção de compromissos e obrigações e quaisquer outras finalidades, em qualquer tempo e sob qualquer condição. É proibida a reprodução ou utilização total ou parcial do presente sem a identificação da fonte.

7. GERAÇÃO TÉRMICA

A Figura 5 apresenta, para cada subsistema, o despacho térmico por modalidade indicado pelo Decomp para a próxima semana operativa.

Figura 5 – Geração térmica para a próxima semana operativa

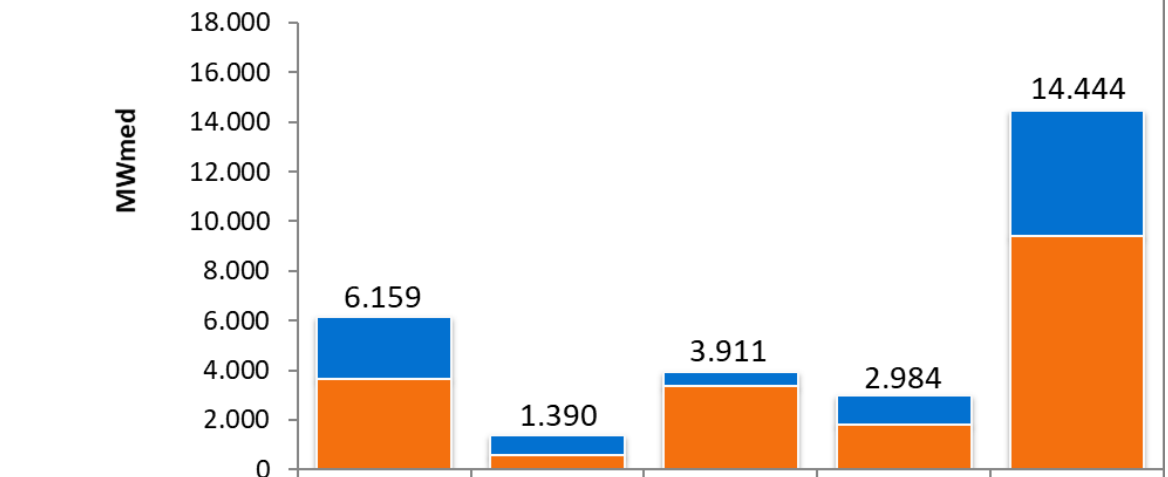

	SE/CO	SUL	NE	NORTE	SIN
RESTRIÇÃO ELÉTRICA	0	0	0	0	0
INFLEXIBILIDADE	2527	820	533	1165	5045
ORDEM DE MÉRITO	3632	570	3378	1819	9399

Na tabela abaixo segue a Indicação de despacho antecipado por ordem de mérito de custo para a semana de 06/11 a 12/11/2021.

Tabela 4 – UTEs com contrato de combustível GNL

UTE			Benefício (R$/MWh)		
Nome	Cod	CVU (R$/MWh)	Carga Pesada	Carga Média	Carga Leve
SANTA CRUZ	86	259,44	1047,90 (1)	1047,90 (1)	1047,90 (1)
LUIZORMELO	15	399,11	1047,90 (1)	1047,90 (1)	1047,90 (1)
PSERGIPE I	224	321,29	907,03 (1)	906,80 (1)	906,79 (1)

(1) Comandado o despacho antecipado por ordem de mérito de custo nesse patamar

(2) NÃO foi comandado o despacho antecipado por ordem de mérito de custo nesse patamar

Assim sendo, há previsão de despacho antecipado por ordem de mérito de custo para as UTE Santa Cruz, Luiz O. R. Melo e Porto Sergipe I, para a semana de 06/11 a 12/11/2021.

O conteúdo desta publicação foi produzido pelo ONS com base em dados e informações de conhecimento público. É de responsabilidade exclusiva dos agentes e demais interessados a obtenção de outros dados e informações, a realização de análises, estudos e avaliações para fins de tomada de decisões, definição de estratégias de atuação, assunção de compromissos e obrigações e quaisquer outras finalidades, em qualquer tempo e sob qualquer condição. É proibida a reprodução ou utilização total ou parcial do presente sem a identificação da fonte.

8. IMPORTAÇÃO DE ENERGIA DA REPÚBLICA ORIENTAL DO URUGUAI

6.1 República Oriental do Uruguai

Para esta semana operativa, foram declaradas as seguintes ofertas de importação de energia da República Oriental do Uruguai para o Sistema Interligado Nacional - SIN através das conversoras de Rivera (70 MW) e Melo (500 MW).

- **Eletrobras**

Tabela 5 – Energia ofertada para importação

	Oferta de Energia para a Semana de 04/09 a 10/09 (MWmed)				
	Bloco 1	Bloco 2	Bloco 3	Bloco 4	Total
Carga Pesada	100	50	85	50	285
Carga Média	100	50	85	50	285
Carga Leve	100	50	85	50	285
CVU (R$/MWh)	1.158,30	1.356,97	1.707,22	1.894,87	

- **Enel**

Tabela 6 – Energia ofertada para importação

	Oferta de Energia para a Semana de 04/09 a 10/09 (MWmed)				
	Bloco 1	Bloco 2	Bloco 3	Bloco 4	Total
Carga Pesada	100	50	85	50	285
Carga Média	100	50	85	50	285
Carga Leve	100	50	85	50	285
CVU (R$/MWh)	1.148,38	1.340,61	1.695,95	1.882,97	

Conforme declaração do agente, esta importação poderá ser realizada exclusivamente pela conversora Melo.

6.2 República da Argentina

Para a próxima semana operativa, foi declarada a seguinte oferta de importação de energia da República da Argentina para o SIN através das conversoras de Garabi 1 (1.100 MW) e Garabi 2 (1.100 MW).

- **Enel**

Tabela 7 – Energia ofertada para importação

	Oferta de Energia para a Semana de 04/09 a 10/09 (MWmed)					
	Bloco 1	Bloco 2	Bloco 3	Bloco 4	Bloco 5	Total
Carga Pesada	200	300	300	800	600	2.200
Carga Média	200	300	300	800	600	2.200
Carga Leve	200	300	300	800	600	2.200
CVU (R$/MWh)	1.301,44	1.363,13	1.488,85	1.673,45	1.927,68	

Nota: Detalhes sobre a importação de energia vide Portaria Nº 339, de 15 de agosto de 2018 disponível em: http://pesquisa.in.gov.br/imprensa/jsp/visualiza/index.jsp?data=17/08/2018&jornal=515&pagina=60&totalArquivos=136

O conteúdo desta publicação foi produzido pelo ONS com base em dados e informações de conhecimento público. É de responsabilidade exclusiva dos agentes e demais interessados a obtenção de outros dados e informações, a realização de análises, estudos e avaliações para fins de tomada de decisões, definição de estratégias de atuação, assunção de compromissos e obrigações e quaisquer outras finalidades, em qualquer tempo e sob qualquer condição. É proibida a reprodução ou utilização total ou parcial do presente sem a identificação da fonte.

9. ARMAZENAMENTOS OPERATIVOS

Para uma melhor avaliação de diversos cenários hidrometeorológicos, notadamente, aqueles de curto prazo e suas influências nas previsões de vazões nos subsistemas, os resultados desta revisão do PMO contemplam cenários de afluências visando melhor representar a ocorrência de precipitação e, consequentemente, seus efeitos sobre as afluências e armazenamentos.

Além dos resultados associados ao valor esperado das previsões de afluências, as simulações operativas também foram realizadas com os limites superior e inferior das previsões de afluências. Apresentamos a seguir os resultados obtidos com a aplicação dos diferentes cenários de afluência.

Tabela 8 – Previsão de ENA dos cenários de sensibilidade

Subsistema	ENERGIAS NATURAIS AFLUENTES					
	Previsão Mensal					
	LI		VE		LS	
	(MWmed)	%MLT	(MWmed)	%MLT	(MWmed)	%MLT
SE/CO	9.232	**47**	10.951	**56**	12.858	**65**
Sul	2.978	**25**	6.310	**54**	9.847	**84**
Nordeste	1.221	**41**	1.378	**46**	1.536	**52**
Norte	1.503	**66**	1.694	**74**	1.890	**83**

Tabela 9 – Previsão de %EARmáx para o final do mês

Subsistema	% EARmáx 03/09	% EARmáx - 30/09		
	NÍVEL INICIAL	NÍVEL PMO		
	VE	LI	VE	LS
SE/CO	20,7	14,2	15,2	15,7
Sul	26,5	13,2	22,6	28,6
Nordeste	48,1	40,7	40,1	40,3
Norte	69,7	62,3	62,5	63,0

O conteúdo desta publicação foi produzido pelo ONS com base em dados e informações de conhecimento público. É de responsabilidade exclusiva dos agentes e demais interessados a obtenção de outros dados e informações, a realização de análises, estudos e avaliações para fins de tomada de decisões, definição de estratégias de atuação, assunção de compromissos e obrigações e quaisquer outras finalidades, em qualquer tempo e sob qualquer condição. É proibida a reprodução ou utilização total ou parcial do presente sem a identificação da fonte.

10. RESERVATÓRIOS EQUIVALENTES DE ENERGIA

A seguir são apresentadas as previsões de Energia Natural Afluente para a próxima semana operativa e para o mês de setembro, bem como as previsões de Energia Armazenada nos Reservatórios Equivalentes de Energia – REE, desta revisão do PMO.

Tabela 10 – Previsão de ENA por REE

Valor Esperado das Energias Naturais Afluentes				
REE	Previsão Semanal		Previsão Mensal	
	04/09/2021 a 10/09/2021		set/21	
	(MWmed)	%MLT	(MWmed)	%MLT
Sudeste	1.294	53	1.358	56
Madeira	1.220	68	1.341	75
Teles Pires	478	70	472	69
Itaipu	1.950	73	1.957	73
Paraná	4.904	49	4.979	49
Paranapanema	744	36	859	42
Sul	2.564	37	4.875	70
Iguaçu	919	19	1.435	30
Nordeste	1.390	47	1.378	46
Norte	1.035	70	967	65
Belo Monte	120	32	111	29
Manaus	746	173	650	151

Tabela 11 – Previsão de %EARmáx por REE

% Energia Armazenável Máxima		
REE	Previsão Semanal	Previsão Mensal
	10-set	30-set
	(%EARmáx)	(%EARmáx)
Sudeste	27,9	23,7
Madeira	41,5	25,4
Teles Pires	56,3	36,1
Itaipu	25,4	41,3
Paraná	14,6	10,3
Paranapanema	31,9	32,1
Sul	32,7	34,8
Iguaçu	18,5	11,6
Nordeste	46,0	40,1
Norte	66,9	62,0
Belo Monte	96,7	89,5
Manaus	82,5	71,4

O conteúdo desta publicação foi produzido pelo ONS com base em dados e informações de conhecimento público. É de responsabilidade exclusiva dos agentes e demais interessados a obtenção de outros dados e informações, a realização de análises, estudos e avaliações para fins de tomada de decisões, definição de estratégias de atuação, assunção de compromissos e obrigações e quaisquer outras finalidades, em qualquer tempo e sob qualquer condição. É proibida a reprodução ou utilização total ou parcial do presente sem a identificação da fonte.

11. DESPACHO TÉRMICO POR MODALIDADE, PATAMAR DE CARGA E USINA

Nas tabelas abaixo, a diferenciação entre geração por inflexibilidade e por ordem de mérito tem caráter informativo, com o objetivo de detalhar a informação de inflexibilidade enviada pelos respectivos agentes para esta revisão do PMO. Ressalta-se que nas etapas de Programação Diária e Tempo Real, o montante despachado nas usinas termelétricas indicadas por ordem de mérito é plenamente intitulado como ordem de mérito.

REGIÃO SUDESTE/CENTRO-OESTE																	
Térmicas Potência (MW)	Combustível	CVU (R$/MWh)	Inflexibilidade			Ordem de Mérito			Total Mérito e INFL.			Razão Elétrica			Total UTE		
			P	M	L	P	M	L	P	M	L	P	M	L	P	M	L
ATLAN_CSA (255)	Resíduos	0,00	150,0	150,0	150,0				150,0	150,0	150,0				150,0	150,0	150,0
ANGRA 2 (1350)	Nuclear	20,12	1350,0	1350,0	1350,0	0,0	0,0	0,0	1350,0	1350,0	1350,0				1350,0	1350,0	1350,0
ANGRA 1 (640)	Nuclear	31,17	640,0	640,0	640,0	0,0	0,0	0,0	640,0	640,0	640,0				640,0	640,0	640,0
NORTEFLU 1 (400)	Gás	80,69				0,0	0,0	0,0	0,0	0,0	0,0				0,0	0,0	0,0
NORTEFLU 2 (100)	Gás	92,91				0,0	0,0	0,0	0,0	0,0	0,0				0,0	0,0	0,0
O.PINTADA (50)	Biomassa	112,47	7,0	7,0	7,0	43,0	43,0	43,0	50,0	50,0	50,0				50,0	50,0	50,0
UTE STA VI (41)	Biomassa	121,49	13,0	13,0	13,0	28,4	28,4	28,4	41,4	41,4	41,4				41,4	41,4	41,4
PREDILECTA (5)	Biomassa	158,95	1,0	1,0	1,0	4,0	4,0	4,0	5,0	5,0	5,0				5,0	5,0	5,0
NORTEFLU 3 (200)	Gás	176,88				0,0	0,0	0,0	0,0	0,0	0,0				0,0	0,0	0,0
ATLANTICO (235)	Resíduos	206,08	218,7	218,7	218,7	0,0	0,0	0,0	218,7	218,7	218,7				218,7	218,7	218,7
BAIXADA FL (530)	Gás	255,86				530,0	530,0	530,0	530,0	530,0	530,0				530,0	530,0	530,0
SANTA CRUZ (500)	GNL	259,44				0,0	0,0	0,0	0,0	0,0	0,0				0,0	0,0	0,0
T.LAGOAS (350)	Gás	263,19				270,0	250,0	230,9	270,0	250,0	230,9				270,0	250,0	230,9
JUIZ DE FO (87)	Gás	283,74				75,0	75,0	75,0	75,0	75,0	75,0				75,0	75,0	75,0
ST.CRUZ 34 (436)	Óleo	310,41															
TERMORIO (1036)	Gás	330,93	100,0	100,0	100,0	800,0	800,0	800,0	900,0	900,0	900,0				900,0	900,0	900,0
CUBATAO (216)	Gás	357,66	20,0	41,0	61,1	0,0	0,0	0,0	20,0	41,0	61,1				20,0	41,0	61,1
LUIZORMELO (204)	GNL	399,11				0,0	0,0	0,0	0,0	0,0	0,0				0,0	0,0	0,0
SEROPEDICA (386)	Gás	411,59				355,0	350,0	349,6	355,0	350,0	349,6				355,0	350,0	349,6
PIRAT.12 O (200)	Gás	470,34															
NPIRATINGA (572)	Gás	548,04				545,6	545,6	545,6	545,6	545,6	545,6				545,6	545,6	545,6
NORTEFLU 4 (127)	Gás	631,70				0,0	0,0	0,0	0,0	0,0	0,0				0,0	0,0	0,0
T.MACAE (929)	Gás	739,82				836,0	836,0	836,0	836,0	836,0	836,0				836,0	836,0	836,0
PALMEIR_GO (176)	Diesel	763,77				0,0	0,0	0,0	0,0	0,0	0,0				0,0	0,0	0,0
IBIRITE (226)	Gás	781,76				0,0	0,0	0,0	0,0	0,0	0,0				0,0	0,0	0,0
TNORTE 2 (340)	Óleo	910,86				0,0	0,0	0,0	0,0	0,0	0,0				0,0	0,0	0,0
VIANA (175)	Óleo	960,28				174,6	174,6	174,6	174,6	174,6	174,6				174,6	174,6	174,6
CAMPOS (25)	Gás	978,10															
DAIA (44)	Diesel	1020,95				0,0	0,0	0,0	0,0	0,0	0,0				0,0	0,0	0,0
GOIANIA 2 (140)	Diesel	1067,44				0,0	0,0	0,0	0,0	0,0	0,0				0,0	0,0	0,0
CUIABA CC (529)	Gás	1393,69															
XAVANTES (54)	Diesel	1467,03															
W.ARJONA O	Diesel	2042,39															
W.ARJONA (177)	Gás	2443,68															
TOTAL SE/CO (10735)			2499,7	2520,7	2540,8	3661,6	3636,6	3617,1	6161,3	6157,3	6157,9	0,0	0,0	0,0	6161,3	6157,3	6319,9

REGIÃO SUL																	
Térmicas Potência (MW)	Combustível	CVU (R$/MWh)	Inflexibilidade			Ordem de Mérito			Total Mérito e INFL.			Razão Elétrica			Total UTE		
			P	M	L	P	M	L	P	M	L	P	M	L	P	M	L
PAMPA SUL (345)	Carvão	69,75				0,0	0,0	0,0	0,0	0,0	0,0				0,0	0,0	0,0
SAO SEPE (8)	Biomassa	87,75	8,0	8,0	8,0	0,0	0,0	0,0	8,0	8,0	8,0				8,0	8,0	8,0
CANDIOTA_3 (350)	Carvão	92,68	310,0	310,0	310,0	0,0	0,0	0,0	310,0	310,0	310,0				310,0	310,0	310,0
J.LACER. C (363)	Carvão	229,27	160,0	160,0	160,0	170,0	170,0	170,0	330,0	330,0	330,0				330,0	330,0	330,0
J.LACER. B (262)	Carvão	271,21	200,0	200,0	200,0	20,0	20,0	20,0	220,0	220,0	220,0				220,0	220,0	220,0
J.LAC. A2 (132)	Carvão	278,38	70,0	70,0	70,0	40,0	40,0	40,0	110,0	110,0	110,0				110,0	110,0	110,0
J.LAC. A1 (100)	Carvão	304,61	70,0	70,0	70,0	10,0	5,8	0,0	80,0	75,8	70,0				80,0	75,8	70,0
MADEIRA (4)	Biomassa	332,22	2,0	2,0	2,0	1,0	1,0	1,0	3,0	3,0	3,0				3,0	3,0	3,0
FIGUEIRA (20)	Carvão	475,68				0,0	0,0	0,0	0,0	0,0	0,0				0,0	0,0	0,0
CANOAS (249)	Diesel	698,14				230,0	230,0	230,0	230,0	230,0	230,0				230,0	230,0	230,0
ARAUCARIA (484)	Gás	1276,44				233,0	233,0		233,0	233,0					233,0	233,0	0,0
URUGUAIANA (640)	Gás	1589,58															
TOTAL SUL (2957)			820,0	820,0	820,0	704,0	699,8	461,0	1524,0	1519,8	1281,0	0,0	0,0	0,0	1524,0	1519,8	1281,0

O conteúdo desta publicação foi produzido pelo ONS com base em dados e informações de conhecimento público. É de responsabilidade exclusiva dos agentes e demais interessados a obtenção de outros dados e informações, a realização de análises, estudos e avaliações para fins de tomada de decisões, definição de estratégias de atuação, assunção de compromissos e obrigações e quaisquer outras finalidades, em qualquer tempo e sob qualquer condição. É proibida a reprodução ou utilização total ou parcial do presente sem a identificação da fonte.

REGIÃO NORDESTE																	
Térmicas Potência (MW)	Combustível	CVU (R$/MWh)	Inflexibilidade			Ordem de Mérito			Total Mérito e INFL.			Razão Elétrica			Total UTE		
			P	M	L	P	M	L	P	M	L	P	M	L	P	M	L
ALTOS (13)	Diesel	---															
ARACATI (11)	Diesel	---															
BATURITE (11)	Diesel	---															
C.MAIOR (13)	Diesel	---															
CAUCAIA (15)	Diesel	---															
CRATO (13)	Diesel	---															
IGUATU (15)	Diesel	---															
JUAZEIRO N (15)	Diesel	---															
MARAMBAIA (13)	Diesel	---															
NAZARIA (13)	Diesel	---															
PECEM (15)	Diesel	---															
ERB CANDEI (17)	Biomassa	87,81				0,0	0,0	0,0	0,0	0,0	0,0				0,0	0,0	0,0
PROSPERIDA (28)	Gás	165,61				28,0	28,0	28,0	28,0	28,0	28,0				28,0	28,0	28,0
TERMOPE (533)	Gás	178,30	532,7	532,7	532,7	0,0	0,0	0,0	532,7	532,7	532,7				532,7	532,7	532,7
FORTALEZA (327)	Gás	245,46				326,6	326,6	326,6	326,6	326,6	326,6				326,6	326,6	326,6
PSERGIPE I (1516)	GNL	321,29				1040,0	1040,0	1040,0	1040,0	1040,0	1040,0				1040,0	1040,0	1040,0
P.PECEM2 (365)	Carvão	395,03				365,0	365,0	365,0	365,0	365,0	365,0				365,0	365,0	365,0
P.PECEM1 (720)	Carvão	396,09				720,0	720,0	720,0	720,0	720,0	720,0				720,0	720,0	720,0
SYKUE I (30)	Biomassa	510,12				0,0	0,0	0,0	0,0	0,0	0,0				0,0	0,0	0,0
BAHIA_1 (31)	Óleo	819,79				26,0	26,0	26,0	26,0	26,0	26,0				26,0	26,0	26,0
PERNAMBU_3 (201)	Óleo	828,69				0,0	0,0	0,0	0,0	0,0	0,0				0,0	0,0	0,0
VALE ACU (368)	Gás	829,28				110,0	110,0	110,0	110,0	110,0	110,0				110,0	110,0	110,0
T.BAHIA (186)	Gás	854,01				158,9	158,9	158,9	158,9	158,9	158,9				158,9	158,9	158,9
MARACANAU (168)	Óleo	934,51				101,0	101,0	101,0	101,0	101,0	101,0				101,0	101,0	101,0
TERMOCABO (50)	Óleo	948,48				24,8	25,7	26,6	24,8	25,7	26,6				24,8	25,7	26,6
TERMONE (171)	Óleo	951,70				162,0	162,0	162,0	162,0	162,0	162,0				162,0	162,0	162,0
TERMOPB (171)	Óleo	951,70				154,0	154,0	154,0	154,0	154,0	154,0				154,0	154,0	154,0
CAMPINA_GR (169)	Óleo	960,30				135,0	114,2		135,0	114,2					135,0	114,2	0,0
SUAPE II (381)	Óleo	982,95				364,2			364,2						364,2	0,0	0,0
POTIGUAR_3 (66)	Diesel	1004,31				36,0			36,0						36,0	0,0	0,0
POTIGUAR (53)	Diesel	1004,32				37,8			37,8						37,8	0,0	0,0
AREMBEPE (150)	Óleo	1023,71															
MURICY (147)	Óleo	1023,71															
GLOBAL I (149)	Óleo	1087,89															
GLOBAL II (149)	Óleo	1087,89															
PETROLINA (136)	Óleo	1123,16															
PAU FERRO (94)	Diesel	1136,93															
TERMOMANAU (143)	Diesel	1136,93															
TERMOCEARA (223)	Diesel	1551,12															
TOTAL NE (6889)			532,7	532,7	532,7	2749,3	2291,4	2178,1	3282,0	2824,1	2710,8	####	####	####	4322,0	3864,1	3750,8

REGIÃO NORTE																	
Térmicas Potência (MW)	Combustível	CVU (R$/MWh)	Inflexibilidade			Ordem de Mérito			Total Mérito e INFL.			Razão Elétrica			Total UTE		
			P	M	L	P	M	L	P	M	L	P	M	L	P	M	L
C. ROCHA (85)	Gás	0,00	65,0	65,0	65,0				65,0	65,0	65,0				65,0	65,0	65,0
JARAQUI (75)	Gás	0,00	63,0	63,0	63,0				63,0	63,0	63,0				63,0	63,0	63,0
MANAUARA (67)	Gás	0,00	64,5	64,5	64,5				64,5	64,5	64,5				64,5	64,5	64,5
PONTA NEGR (66)	Gás	0,00	64,0	64,0	64,0				64,0	64,0	64,0				64,0	64,0	64,0
TAMBAQUI (93)	Gás	0,00	63,0	63,0	63,0				63,0	63,0	63,0				63,0	63,0	63,0
MARANHAO3 (519)	Gás	85,72	490,0	514,0	511,3	0,0	0,0	0,0	490,0	514,0	511,3				490,0	514,0	511,3
APARECIDA (166)	Gás	118,96	75,0	75,0	75,0	71,0	71,0	70,3	146,0	146,0	145,3				146,0	146,0	145,3
UTE MAUA 3 (591)	Gás	118,96	264,0	264,0	264,0	200,0	200,0	200,0	464,0	464,0	464,0				464,0	464,0	464,0
PARNAIB_IV (56)	Gás	151,69				56,3	56,3	56,3	56,3	56,3	56,3				56,3	56,3	56,3
N.VEN2_L22 (27)	Gás	232,27				27,0	24,0	21,1	27,0	24,0	21,1				27,0	24,0	21,1
N.VEN2_L7 (151)	Gás	232,27				143,0	133,5	116,1	143,0	133,5	116,1				143,0	133,5	116,1
MARAN_VL_7 (336)	Gás	238,24				323,9	334,4	333,2	323,9	334,4	333,2				323,9	334,4	333,2
MARANIVL_7 (336)	Gás	238,24				323,8	334,3	333,1	323,8	334,3	333,1				323,8	334,3	333,1
MARAN_VL22 (1)	Gás	238,25				1,1	1,1	1,1	1,1	1,1	1,1				1,1	1,1	1,1
MARANIVL22 (1)	Gás	238,25				1,1	1,1	1,1	1,1	1,1	1,1				1,1	1,1	1,1
P. ITAQUI (360)	Carvão	388,25				360,1	360,1	360,1	360,1	360,1	360,1				360,1	360,1	360,1
GERAMAR1 (166)	Óleo	960,26				159,2	159,2	159,2	159,2	159,2	159,2				159,2	159,2	159,2
GERAMAR2 (166)	Óleo	960,26				159,2	159,2	159,2	159,2	159,2	159,2				159,2	159,2	159,2
TOTAL NORTE (3264)			1148,5	1172,5	1169,8	1825,7	1834,2	1810,8	2974,2	3006,7	2980,6	0,0	0,0	0,0	2974,2	3006,7	2980,6

O conteúdo desta publicação foi produzido pelo ONS com base em dados e informações de conhecimento público. É de responsabilidade exclusiva dos agentes e demais interessados a obtenção de outros dados e informações, a realização de análises, estudos e avaliações para fins de tomada de decisões, definição de estratégias de atuação, assunção de compromissos e obrigações e quaisquer outras finalidades, em qualquer tempo e sob qualquer condição. É proibida a reprodução ou utilização total ou parcial do presente sem a identificação da fonte.