1. APRESENTAÇÃO

Na semana de 31/10 a 06/11/2020 ocorreu chuva fraca nas bacias hidrográficas do subsistema Sul, na bacia do rio Jacuí, em pontos isolados da bacia do rio Paranapanema e na incremental a UHE Itaipu.

Na semana de 07/11/2020 a 13/11/2020 deve ocorrer chuva fraca nas bacias dos rios Paranapanema, Tietê, Grande, Paranaíba e em pontos isolados do Uruguai e do Iguaçu. E nas bacias hidrográficas da região Norte deve ocorrer pancadas de chuva em pontos isolados.

Para a semana operativa de 07/11 a 13/11/2020, houve oferta de energia da República Oriental do Uruguai e da República da Argentina. De acordo com o Art. 2º da Portaria MME nº 339, de 15 de agosto de 2018, as ofertas para importação de energia não foram consideradas na elaboração do PMO.

Os valores médios semanais do Custo Marginal de Operação – CMO dos subsistemas do SIN sofreram as seguintes alterações em relação à semana anterior:

- SE/CO: de R$ 368,03/MWh para R$ 630,47/MWh
- Sul: de R$ 368,03/MWh para R$ 630,47/MWh
- Nordeste: de R$ 150,64/MWh para R$ 197,08/MWh
- Norte: de R$ 368,03/MWh para R$ 630,47/MWh

Desde o dia 01/01/2020, o despacho por ordem de mérito é indicado diariamente pelos resultados do modelo DESSEM. Assim, o despacho por ordem de mérito semanal, conforme publicado nesse documento, tem caráter apenas informativo.

2. NOTÍCIAS

Nos dias 26 e 27 de novembro será realizada a reunião de elaboração do PMO Dezembro de 2020, com transmissão ao vivo através do site do ONS.

Como medida adicional de prevenção ao Coronavírus, o ONS informa que está suspensa, temporariamente, a participação presencial nas reuniões.

3. ANÁLISE DAS CONDIÇÕES HIDROMETEOROLÓGICAS

3.1. PREVISÃO PARA A PRÓXIMA SEMANA

A atuação de um sistema de baixa pressão no estado do Paraná e nas regiões Sudeste e Centro-Oeste ocasiona chuva fraca nas bacias dos rios Paranapanema, Tietê, Grande, Paranaíba e em pontos isolados do Uruguai e do Iguaçu **(Figura 1).** As bacias hidrográficas da região Norte apresentam pancadas de chuva em pontos isolados.

O conteúdo desta publicação foi produzido pelo ONS com base em dados e informações de conhecimento público. É de responsabilidade exclusiva dos agentes e demais interessados a obtenção de outros dados e informações, a realização de análises, estudos e avaliações para fins de tomada de decisões, definição de estratégias de atuação, assunção de compromissos e obrigações e quaisquer outras finalidades, em qualquer tempo e sob qualquer condição. É proibida a reprodução ou utilização total ou parcial do presente sem a identificação da fonte.

Figura 1 - Precipitação acumulada prevista pelo modelo ECMWF (ECMWF) para o período de 07 a 13/11/2020

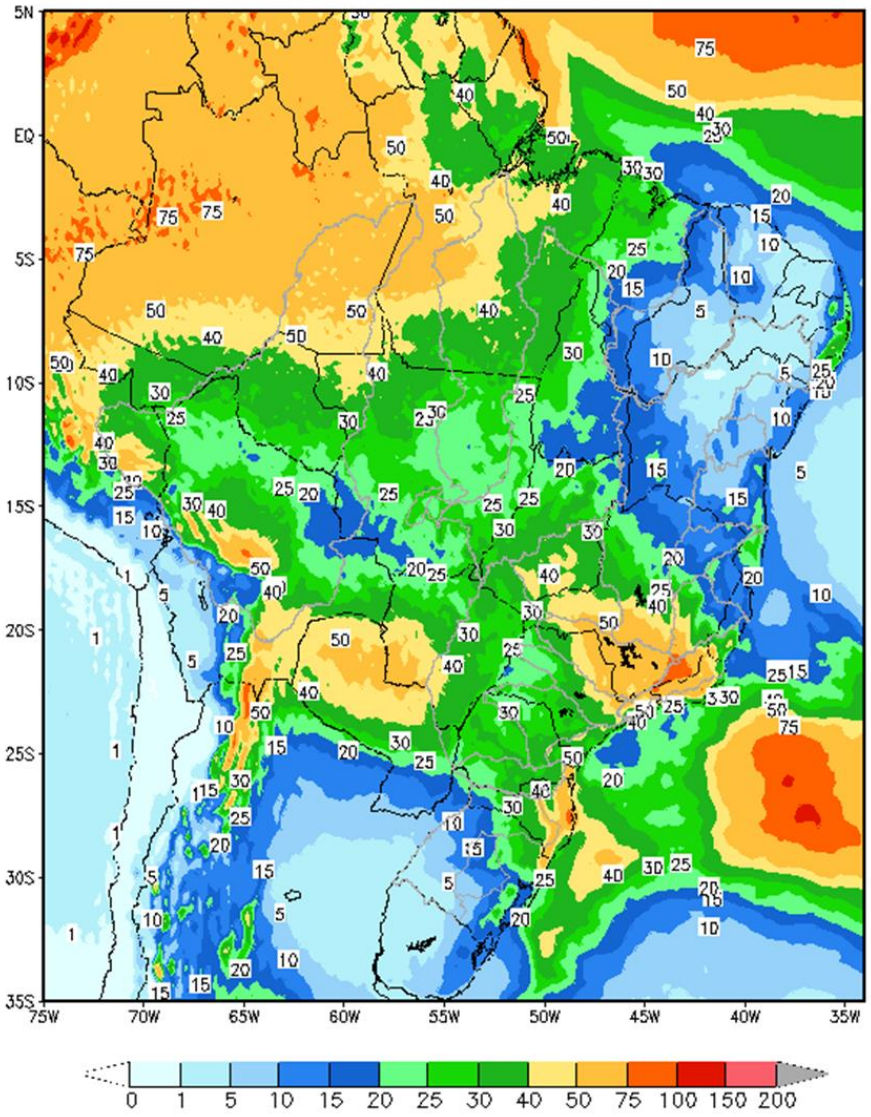

Em comparação com os valores estimados para a semana em curso, prevê-se para a próxima semana operativa recessão nas afluências dos subsistemas Sudeste e ascensão nas afluências dos subsistemas Sul, Nordeste e Norte. A previsão mensal para outubro indica a ocorrência de afluências abaixo da média histórica para todos os subsistemas.

Tabela 1 – Tendência hidrológica da ENA da revisão 1 de novembro/2020

Revisão 1 do PMO de Novembro/2020 - ENAs previstas				
Subsistema	7/11 a 13/11/2020		Mês de Novembro	
	MWmed	%MLT	MWmed	%MLT
SE/CO	14.530	46	17.738	56
S	1.746	19	2.113	22
NE	4.958	93	4.818	90
N	3.566	88	3.590	89

O conteúdo desta publicação foi produzido pelo ONS com base em dados e informações de conhecimento público. É de responsabilidade exclusiva dos agentes e demais interessados a obtenção de outros dados e informações, a realização de análises, estudos e avaliações para fins de tomada de decisões, definição de estratégias de atuação, assunção de compromissos e obrigações e quaisquer outras finalidades, em qualquer tempo e sob qualquer condição. É proibida a reprodução ou utilização total ou parcial do presente sem a identificação da fonte.

4. PREVISÃO DE CARGA

A sondagem industrial de outubro disponibilizada pela Fundação Getúlio Vargas – FGV mostra que o índice de confiança da indústria avançou 4,5% em outubro, alcançando 111,2 pontos, sendo esse o maior nível desde abril 2011 (111,6 pontos). Além disso, destaca-se o aumento de 1,6 ponto percentual do Nível de Utilização da Capacidade Instalada, de 78,2% para 79,8%, maior valor desde novembro de 2014 (70,3%). Esses fatores corroboram com a afirmação de que as atividades econômicas continuam em recuperação (produção industrial, comércio, serviços, etc), pós efeito do isolamento social em função da pandemia, o que tem se refletido positivamente no comportamento da carga.

As sinalizações meteorológicas para a próxima semana nas capitais dos subsistemas Sudeste/Centro-Oeste e Sul, indicam elevação das temperaturas máximas e mínimas em relação a semana em curso, quando foram observadas temperaturas bastante amenas e atípicas para essa época do ano, caracterizando, inclusive um período chamado de "invernico". No subsistema Nordeste, durante a semana em curso, houve precipitação e declínio de temperaturas em Salvador, porém para a próxima semana as capitais do Nordeste e Norte seguem com expectativa de ocorrência de temperaturas e totais de precipitação típicos para essa época do ano.

As taxas de crescimento previstas para o mês de novembro em relação ao mesmo mês de 2019, são de 0,4% no subsistema Sudeste/Centro-Oeste, 0,6% para o subsistema Sul, 0,9% no Nordeste e 6,5% no subsistema do Norte.

Ressalta-se que a taxa de crescimento expressiva do subsistema Norte está associada ao retorno da carga de um consumidor livre da rede básica.

Tabela 2 – Evolução da carga do PMO de novembro/2020

Subsistema	CARGA SEMANAL (MWmed)					CARGA MENSAL (MWmed)	
	1ª Sem	2ª Sem	3ª Sem	4ª Sem	5ª Sem	nov/20	Var. (%) nov/20 -> nov/19
Sudeste	36.606	39.510	40.598	41.293	41.504	39.799	0,4%
Sul	11.220	12.022	12.255	12.444	12.442	12.056	0,6%
Nordeste	11.509	11.950	11.898	11.956	12.002	11.856	0,9%
Norte	5.803	6.203	6.169	6.258	6.267	6.134	6,5%
SIN	65.138	69.685	70.920	71.951	72.215	69.845	1,0%

O conteúdo desta publicação foi produzido pelo ONS com base em dados e informações de conhecimento público. É de responsabilidade exclusiva dos agentes e demais interessados a obtenção de outros dados e informações, a realização de análises, estudos e avaliações para fins de tomada de decisões, definição de estratégias de atuação, assunção de compromissos e obrigações e quaisquer outras finalidades, em qualquer tempo e sob qualquer condição. É proibida a reprodução ou utilização total ou parcial do presente sem a identificação da fonte.

5. PRINCIPAIS RESULTADOS

5.1. CUSTO MARGINAL DE OPERAÇÃO (CMO)

A tabela a seguir apresenta o CMO, por subsistema e patamar de carga para próxima semana operativa.

Tabela 3 – CMO por patamar de carga

Patamares de Carga	CMO (R$/MWh)			
	SE/CO	S	NE	N
Pesada	643,37	643,37	223,72	643,37
Média	639,90	639,90	190,10	639,90
Leve	618,88	618,88	188,01	618,88
Média Semanal	630,47	630,47	197,08	630,47

Na figura a seguir é apresentada a evolução do CMO médio semanal ao longo deste PMO.

Figura 2 – Evolução semanal do CMO

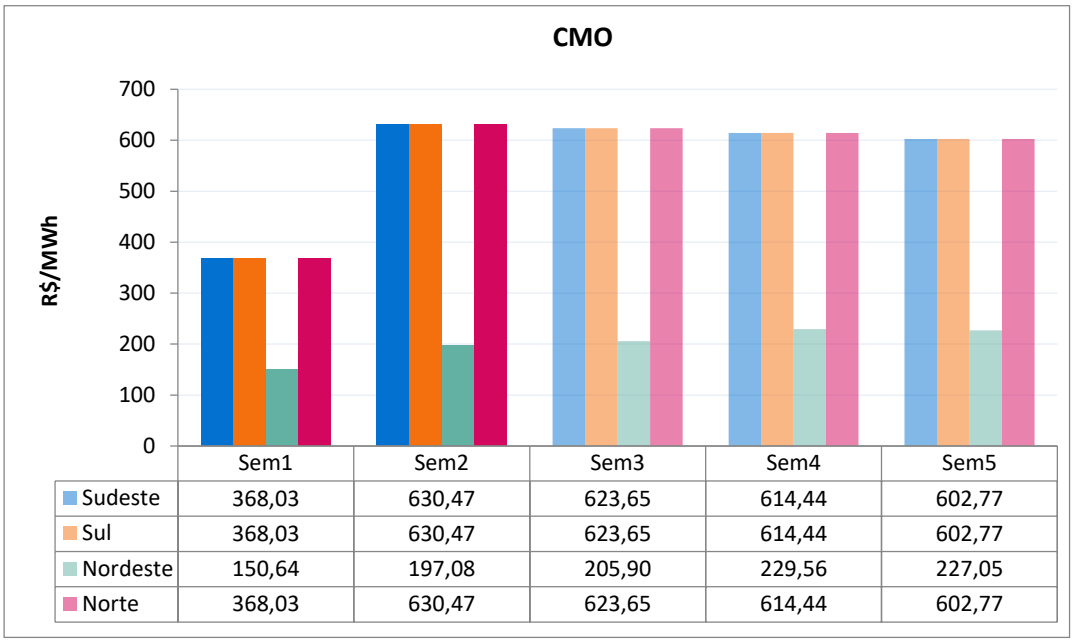

5.2. POLÍTICA DE OPERAÇÃO ENERGÉTICA

Para esta semana operativa, está prevista a seguinte política de intercâmbio de energia entre regiões:

Região SE/CO → Geração dimensionada para fechamento do balanço energético do SIN.

Região Sul → Predominantemente importador, respeitando-se os limites elétricos vigentes, tendo sua geração minimizada sempre que possível.

Região NE → Intercâmbio de energia definido em função dos recursos energéticos da região, buscando-se a máxima exploração, respeitando-se os limites elétricos vigentes para o subsistema.

Região Norte → Geração dimensionada de forma a otimizar os recursos desta região e buscando-se a aderência a curva guia para o armazenamento da UHE Tucuruí.

O conteúdo desta publicação foi produzido pelo ONS com base em dados e informações de conhecimento público. É de responsabilidade exclusiva dos agentes e demais interessados a obtenção de outros dados e informações, a realização de análises, estudos e avaliações para fins de tomada de decisões, definição de estratégias de atuação, assunção de compromissos e obrigações e quaisquer outras finalidades, em qualquer tempo e sob qualquer condição. É proibida a reprodução ou utilização total ou parcial do presente sem a identificação da fonte.

6. GERAÇÃO TÉRMICA

A Figura 3 apresenta, para cada subsistema, o despacho térmico por modalidade, para a próxima semana operativa.

Figura 3 – Geração térmica para a próxima semana operativa

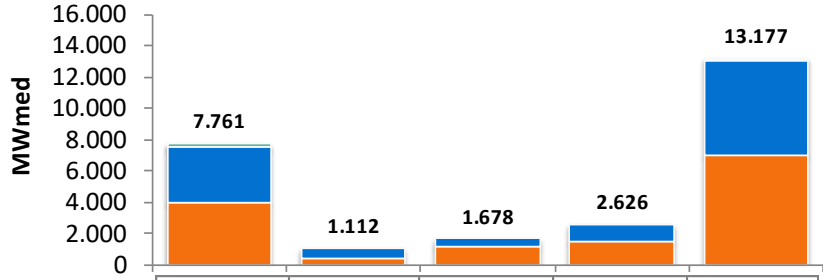

	SE/CO	SUL	NE	NORTE	SIN
INFLEXIBILIDADE	3582	732	561	1149	6024
ORDEM DE MÉRITO	3992	380	1117	1477	6966
RESTRIÇÃO ELÉTRICA	187	0	0	0	187
GARANTIA ENERGÉTICA	0	0	0	0	0

Na tabela abaixo segue a Indicação de despacho antecipado por ordem de mérito de custo para a semana de 09/01/2021 a 15/01/2021.

Tabela 4 – UTEs com contrato de combustível GNL

UTE			Benefício (R$/MWh)		
Nome	Cod	CVU (R$/MWh)	Carga Pesada	Carga Média	Carga Leve
SANTA CRUZ	86	146,33	178,80 (1)	178,80 (1)	178,77 (1)
LUIZORMELO	15	218,79	178,80 (2)	178,80 (2)	178,77 (2)
PSERGIPE I	224	197,79	157,52 (2)	153,14 (2)	147,34 (2)

(1) Comandado o despacho antecipado por ordem de mérito de custo nesse patamar

(2) NÃO foi comandado o despacho antecipado por ordem de mérito de custo nesse patamar

Apesar da UTE Luiz O. R. Melo não estar despachada por ordem de mérito, há necessidade do despacho de, pelo menos, 204 MW dessa usina para reduzir o risco de corte de carga na região de Governador Valadares e na região Norte do Espírito Santo. Desta forma, a UTE Luiz O. R. Melo deverá ser despachada por razão elétrica, na referida semana, em 204 MW.

O conteúdo desta publicação foi produzido pelo ONS com base em dados e informações de conhecimento público. É de responsabilidade exclusiva dos agentes e demais interessados a obtenção de outros dados e informações, a realização de análises, estudos e avaliações para fins de tomada de decisões, definição de estratégias de atuação, assunção de compromissos e obrigações e quaisquer outras finalidades, em qualquer tempo e sob qualquer condição. É proibida a reprodução ou utilização total ou parcial do presente sem a identificação da fonte.

7. IMPORTAÇÃO DE ENERGIA DA REPÚBLICA ORIENTAL DO URUGUAI

7.1. República Oriental do Uruguai

Para a próxima semana operativa, foram declaradas as seguintes ofertas de importação de energia da República Oriental do Uruguai para o Sistema Interligado Nacional - SIN através das conversoras de Rivera (70 MW) e Melo (500 MW).

- **Eletrobras**

Tabela 5 – Energia Ofertada para Importação

	Oferta de Energia para a Semana de 7/11 a 13/11 (MWmed)				
	Bloco 1	Bloco 2	Bloco 3	Bloco 4	Total
Carga Pesada	60,0	90,0	50,0	85,0	285,0
Carga Média	60,0	90,0	50,0	85,0	285,0
Carga Leve	60,0	90,0	50,0	85,0	285,0
CVU (R$/MWh)	950,03	1052,11	1115,37	1268,28	

- **Enel**

Conforme declaração do agente, esta importação poderá ser realizada exclusivamente pela conversora Melo.

Tabela 6 – Energia Ofertada para Importação

	Oferta de Energia para a Semana de 7/11 a 13/11 (MWmed)				
	Bloco 1	Bloco 2	Bloco 3	Bloco 4	Total
Carga Pesada	60,0	90,0	50,0	85,0	285,0
Carga Média	60,0	90,0	50,0	85,0	285,0
Carga Leve	60,0	90,0	50,0	85,0	285,0
CVU (R$/MWh)	968,93	1074,35	1138,62	1295,10	

7.2. República da Argentina

- **Enel**

Para a próxima semana operativa, foi declarada a seguinte oferta de importação de energia da República da Argentina para o SIN através das conversoras de Garabi 1 (1.100 MW) e Garabi 2 (1.100 MW).

Tabela 7 – Energia Ofertada para Importação

	Oferta de Energia para a Semana de 7/11 a 13/11 (MWmed)								
	Bloco 1	Bloco 2	Bloco 3	Bloco 4	Bloco 5	Bloco 6	Bloco 7	Bloco 8	Total
Carga Pesada	200,0	200,0	300,0	300,0	300,0	300,0	200,0	200,0	2000,0
Carga Média	200,0	200,0	300,0	300,0	300,0	300,0	200,0	200,0	2000,0
Carga Leve	200,0	200,0	300,0	300,0	300,0	300,0	200,0	200,0	2000,0
CVU (R$/MWh)	391,54	460,89	737,11	841,13	979,82	1083,83	1293,03	1362,37	

Nota: Detalhes sobre a importação de energia vide Portaria Nº 339, de 15 de Agosto de 2018 disponível em: http://pesquisa.in.gov.br/imprensa/jsp/visualiza/index.jsp?data=17/08/2018&jornal=515&pagina=60&totalArquivos=136

O conteúdo desta publicação foi produzido pelo ONS com base em dados e informações de conhecimento público. É de responsabilidade exclusiva dos agentes e demais interessados a obtenção de outros dados e informações, a realização de análises, estudos e avaliações para fins de tomada de decisões, definição de estratégias de atuação, assunção de compromissos e obrigações e quaisquer outras finalidades, em qualquer tempo e sob qualquer condição. É proibida a reprodução ou utilização total ou parcial do presente sem a identificação da fonte.

8. ESTIMATIVA DE ENCARGOS OPERATIVOS

Para esta semana operativa não há estimativa de encargos operativos.

9. ARMAZENAMENTOS OPERATIVOS

Para uma melhor avaliação de diversos cenários hidrometeorológicos, notadamente, aqueles de curto prazo e suas influências nas previsões de vazões nos subsistemas, os resultados desta revisão do PMO contemplam cenários de afluências visando melhor representar a ocorrência de precipitação e, consequentemente, seus efeitos sobre as afluências e armazenamentos.

Além dos resultados associados ao valor esperado das previsões de afluências, as simulações operativas também foram realizadas com os limites superior e inferior das previsões de afluências. Apresentamos a seguir os resultados obtidos com a aplicação dos diferentes cenários de afluência.

Tabela 8 – Previsão de ENA dos cenários de sensibilidade

Subsistema	ENERGIAS NATURAIS AFLUENTES					
	Previsão Mensal					
	LI		VE		LS	
	(MWmed)	%MLT	(MWmed)	%MLT	(MWmed)	%MLT
Sudeste	14.017	**44**	17.738	**56**	21.864	**69**
Sul	1.404	**15**	2.113	**22**	3.602	**38**
Nordeste	3.628	**68**	4.818	**90**	6.000	**112**
Norte	2.995	**74**	3.590	**89**	4.183	**103**

Tabela 9 – Previsão de %EARmáx para o final do mês

Subsistema	% EARmáx 6/11	% EARmáx - 30/11		
	NÍVEL INICIAL	NÍVEL PMO		
	VE	LI	VE	LS
Sudeste	22,6	17,0	18,6	20,3
Sul	23,0	9,8	11,8	14,3
Nordeste	54,6	47,0	49,5	51,7
Norte	29,0	22,7	26,3	26,5

O conteúdo desta publicação foi produzido pelo ONS com base em dados e informações de conhecimento público. É de responsabilidade exclusiva dos agentes e demais interessados a obtenção de outros dados e informações, a realização de análises, estudos e avaliações para fins de tomada de decisões, definição de estratégias de atuação, assunção de compromissos e obrigações e quaisquer outras finalidades, em qualquer tempo e sob qualquer condição. É proibida a reprodução ou utilização total ou parcial do presente sem a identificação da fonte.

10. RESERVATÓRIOS EQUIVALENTES DE ENERGIA

A seguir são apresentadas as previsões de Energia Natural Afluente para a próxima semana operativa e para o mês de novembro, bem como as previsões de Energia Armazenada nos Reservatórios Equivalentes de Energia – REE, desta revisão do PMO.

Tabela 10 – Previsão de ENA por REE

Valor Esperado das Energias Naturais Afluentes				
REE	Previsão Semanal		Previsão Mensal	
	07/11/2020 a 13/11/2020		nov-20	
	(MWmed)	%MLT	(MWmed)	%MLT
Sudeste	3.492	69	4.049	80
Madeira	1.439	43	1.588	47
Teles Pires	733	54	814	59
Itaipu	1.776	58	1.900	62
Paraná	6.187	38	8.427	52
Paranapanema	864	36	921	39
Sul	1.004	22	1.265	27
Iguaçu	742	15	848	18
Nordeste	4.958	93	4.818	90
Norte	3.059	107	2.986	104
Belo Monte	300	31	417	43
Manaus	267	127	256	122

Tabela 11 – Previsão de %EARmáx por REE

% Energia Armazenável Máxima		
REE	Previsão Semanal	Previsão Mensal
	13-nov	30-nov
	(%EARmáx)	(%EARmáx)
Sudeste	27,5	25,4
Madeira	3,3	0,3
Teles Pires	16,1	3,5
Itaipu	25,3	8,9
Paraná	19,0	16,2
Paranapanema	22,5	20,1
Sul	27,9	20,4
Iguaçu	11,2	4,1
Nordeste	52,9	49,5
Norte	28,7	27,1
Belo Monte	98,1	95,5
Manaus	17,1	9,2

O conteúdo desta publicação foi produzido pelo ONS com base em dados e informações de conhecimento público. É de responsabilidade exclusiva dos agentes e demais interessados a obtenção de outros dados e informações, a realização de análises, estudos e avaliações para fins de tomada de decisões, definição de estratégias de atuação, assunção de compromissos e obrigações e quaisquer outras finalidades, em qualquer tempo e sob qualquer condição. É proibida a reprodução ou utilização total ou parcial do presente sem a identificação da fonte.

11. DESPACHO TÉRMICO POR MODALIDADE, PATAMAR DE CARGA E USINA

Nas tabelas abaixo, a diferenciação entre geração por inflexibilidade e por ordem de mérito tem caráter informativo, com o objetivo de detalhar a informação de inflexibilidade enviada pelos respectivos agentes para esta revisão do PMO. Ressalta-se que nas etapas de Programação Diária e Tempo Real, o montante despachado nas usinas termelétricas indicadas por ordem de mérito é plenamente intitulado como ordem de mérito.

REGIÃO SUDESTE/CENTRO-OESTE

Combustível	Combustível	CVU (R$/MWh)	Inflexibilidade			Ordem de Mérito			Total Mérito e INFL.			Razão Elétrica			Total UTE		
			P	M	L	P	M	L	P	M	L	P	M	L	P	M	L
ATLAN_CSA (255)	Resíduos	0,00	187,3	187,3	187,3				187,3	187,3	187,3				187,3	187,3	187,3
ANGRA 2 (1350)	Nuclear	20,12	1220,0	1220,0	1220,0	0,0	0,0	0,0	1220,0	1220,0	1220,0				1220,0	1220,0	1220,0
ANGRA 1 (640)	Nuclear	31,17	640,0	640,0	640,0	0,0	0,0	0,0	640,0	640,0	640,0				640,0	640,0	640,0
NORTEFLU 1 (400)	Gás	84,46	400,0	400,0	400,0	0,0	0,0	0,0	400,0	400,0	400,0				400,0	400,0	400,0
NORTEFLU 2 (100)	Gás	95,52	100,0	100,0	100,0	0,0	0,0	0,0	100,0	100,0	100,0				100,0	100,0	100,0
UTE STA VI (41)	Biomassa	120,46				36,0	36,0	36,0	36,0	36,0	36,0				36,0	36,0	36,0
BAIXADA FL (530)	Gás	129,50				520,0	520,0	520,0	520,0	520,0	520,0				520,0	520,0	520,0
SANTA CRUZ (500)	GNL	146,33															
NORTEFLU 3 (200)	Gás	183,45	200,0	200,0	200,0	0,0	0,0	0,0	200,0	200,0	200,0				200,0	200,0	200,0
ATLANTICO (235)	Resíduos	193,11	218,7	218,7	218,7	0,0	0,0	0,0	218,7	218,7	218,7				218,7	218,7	218,7
LUIZORMELO (204)	GNL	218,79										187,0	187,0	187,0	187,0	187,0	187,0
T.LAGOAS (350)	Gás	224,50				349,7	349,7	349,7	349,7	349,7	349,7				349,7	349,7	349,7
TERMORIO (1036)	Gás	267,82				846,1	846,1	846,1	846,1	846,1	846,1				846,1	846,1	846,1
JUIZ DE FO (87)	Gás	283,74				70,3	70,3	70,3	70,3	70,3	70,3				70,3	70,3	70,3
ST.CRUZ 34 (436)	Óleo	310,41															
CUBATAO (216)	Gás	335,30				209,0	209,0	209,0	209,0	209,0	209,0				209,0	209,0	209,0
SEROPEDICA (386)	Gás	343,69				308,2	308,2	308,2	308,2	308,2	308,2				308,2	308,2	308,2
IBIRITE (226)	Gás	346,37				222,0	222,0	222,0	222,0	222,0	222,0				222,0	222,0	222,0
NORTEFLU 4 (127)	Gás	386,94	126,0	126,0	126,0	0,0	0,0	0,0	126,0	126,0	126,0				126,0	126,0	126,0
CUIABA CC (529)	Gás	398,40	490,0	490,0	490,0	0,0	0,0	0,0	490,0	490,0	490,0				490,0	490,0	490,0
PIRAT.12 O (200)	Gás	470,34															
NPIRATINGA (572)	Gás	548,04				395,0	395,0	395,0	395,0	395,0	395,0				395,0	395,0	395,0
T.MACAE (929)	Gás	612,13				860,3	860,3	860,3	860,3	860,3	860,3				860,3	860,3	860,3
VIANA (175)	Óleo	613,04				175,0	175,0	175,0	175,0	175,0	175,0				175,0	175,0	175,0
PALMEIR_GO (176)	Diesel	889,29															
TNORTE 2 (340)	Óleo	910,86															
CAMPOS (25)	Gás	978,10															
DAIA (44)	Diesel	1178,79															
GOIANIA 2 (140)	Diesel	1235,94															
XAVANTES (54)	Diesel	1695,36															
TOTAL SE/CO (10503)			3582,00	3582,00	3582,00	3991,6	3991,6	3991,6	7573,6	7573,6	7573,6	187,0	187,0	187,0	7760,6	7760,6	7760,6

REGIÃO SUL

Combustível	Combustível	CVU (R$/MWh)	Inflexibilidade			Ordem de Mérito			Total Mérito e INFL.			Razão Elétrica			Total UTE		
			P	M	L	P	M	L	P	M	L	P	M	L	P	M	L
PAMPA SUL (345)	Carvão	69,15				0,0	0,0	0,0	0,0	0,0	0,0				0,0	0,0	0,0
SAO SEPE (8)	Biomassa	84,44	5,5	5,5	5,5	0,0	0,0	0,0	5,5	5,5	5,5				5,5	5,5	5,5
CANDIOTA_3 (350)	Carvão	86,88				0,0	0,0	0,0	0,0	0,0	0,0				0,0	0,0	0,0
J.LACER. C (363)	Carvão	206,84	310,0	310,0	310,0	53,0	53,0	53,0	363,0	363,0	363,0				363,0	363,0	363,0
J.LACER. B (262)	Carvão	244,14	220,0	220,0	220,0	42,0	42,0	42,0	262,0	262,0	262,0				262,0	262,0	262,0
J.LAC. A2 (132)	Carvão	245,21	114,0	114,0	114,0	18,0	18,0	18,0	132,0	132,0	132,0				132,0	132,0	132,0
J.LAC. A1 (100)	Carvão	270,48	80,0	80,0	80,0	20,0	20,0	20,0	100,0	100,0	100,0				100,0	100,0	100,0
URUGUAIANA (640)	Gás	278,48															
MADEIRA (4)	Biomassa	311,46	2,0	2,0	2,0	1,0	1,0	1,0	3,0	3,0	3,0				3,0	3,0	3,0
FIGUEIRA (20)	Carvão	475,68				0,0	0,0	0,0	0,0	0,0	0,0				0,0	0,0	0,0
ARAUCARIA (484)	Gás	630,54				480,0	480,0		480,0	480,0					480,0	480,0	
CANOAS (249)	Diesel	698,14															
TOTAL SUL (2957)			731,50	731,50	731,50	614,0	614,0	134,0	1345,5	1345,5	865,5	0,0	0,0	0,0	1345,5	1345,5	865,5

O conteúdo desta publicação foi produzido pelo ONS com base em dados e informações de conhecimento público. É de responsabilidade exclusiva dos agentes e demais interessados a obtenção de outros dados e informações, a realização de análises, estudos e avaliações para fins de tomada de decisões, definição de estratégias de atuação, assunção de compromissos e obrigações e quaisquer outras finalidades, em qualquer tempo e sob qualquer condição. É proibida a reprodução ou utilização total ou parcial do presente sem a identificação da fonte.

REGIÃO NORDESTE

Combustível	Combustível	CVU (R$/MWh)	Inflexibilidade			Ordem de Mérito			Total Mérito e INFL.			Razão Elétrica			Total UTE		
			P	M	L	P	M	L	P	M	L	P	M	L	P	M	L
PROSPERIDA (28)	Gás	164,20	28,0	28,0	28,0	0,0	0,0	0,0	28,0	28,0	28,0				28,0	28,0	28,0
P.PECEM1 (720)	Carvão	168,58				720,0	720,0	720,0	720,0	720,0	720,0				720,0	720,0	720,0
P.PECEM2 (365)	Carvão	179,48				365,0	365,0	365,0	365,0	365,0	365,0				365,0	365,0	365,0
TERMOPE (533)	Gás	180,57	532,7	532,7	532,7	0,0	0,0	0,0	532,7	532,7	532,7				532,7	532,7	532,7
PSERGIPE I (1516)	GNL	197,79															
FORTALEZA (327)	Gás	223,72				135,2			135,2						135,2		
VALE ACU (368)	Gás	323,10															
T.BAHIA (186)	Gás	324,22															
T.CAMACARI (120)	Gás	345,02															
TERMOCEARA (223)	Gás	371,29															
SYKUE I (30)	Biomassa	510,12															
PERNAMBU_3 (201)	Óleo	520,44															
MARACANAU (168)	Óleo	590,30															
TERMOCABO (50)	Óleo	605,74															
TERMONE (171)	Óleo	609,68															
TERMOPB (171)	Óleo	609,68															
CAMPINA_GR (169)	Óleo	613,05															
SUAPE II (381)	Óleo	614,74															
GLOBAL I (149)	Óleo	695,86															
GLOBAL II (149)	Óleo	695,86															
BAHIA_1 (31)	Óleo	749,72															
ALTOS (13)	Diesel	1024,34															
ARACATI (11)	Diesel	1024,34															
BATURITE (11)	Diesel	1024,34															
C.MAIOR (13)	Diesel	1024,34															
CAUCAIA (15)	Diesel	1024,34															
CRATO (13)	Diesel	1024,34															
IGUATU (15)	Diesel	1024,34															
JUAZEIRO N (15)	Diesel	1024,34															
MARAMBAIA (13)	Diesel	1024,34															
NAZARIA (13)	Diesel	1024,34															
PECEM (15)	Diesel	1024,34															
AREMBEPE (150)	Óleo	1040,88															
MURICY (147)	Óleo	1040,88															
POTIGUAR_3 (66)	Diesel	1054,12															
POTIGUAR (53)	Diesel	1054,13															
PETROLINA (136)	Óleo	1142,00															
PAU FERRO (94)	Diesel	1192,17															
TERMOMANAU (143)	Diesel	1192,17															
TOTAL NE (6992)			560,70	560,70	560,70	1220,2	1085,0	1085,0	1780,9	1645,7	1645,7	0,0	0,0	0,0	1780,9	1645,7	1645,7

REGIÃO NORTE

Combustível	Combustível	CVU (R$/MWh)	Inflexibilidade			Ordem de Mérito			Total Mérito e INFL.			Razão Elétrica			Total UTE		
			P	M	L	P	M	L	P	M	L	P	M	L	P	M	L
C. ROCHA (85)	Gás	0,0	65,0	65,0	65,0				65,0	65,0	65,0				65,0	65,0	65,0
JARAQUI (75)	Gás	0,0	63,0	63,0	63,0				63,0	63,0	63,0				63,0	63,0	63,0
MANAUARA (67)	Gás	0,0	64,5	64,5	64,5				64,5	64,5	64,5				64,5	64,5	64,5
PONTA NEGR (66)	Gás	0,0	64,0	64,0	64,0				64,0	64,0	64,0				64,0	64,0	64,0
TAMBAQUI (93)	Gás	0,0	63,0	63,0	63,0				63,0	63,0	63,0				63,0	63,0	63,0
APARECIDA (166)	Gás	68,1	75,00	75,00	75,00	58,2	54,2	42,1	133,2	129,2	117,1				133,2	129,2	117,1
UTE MAUA 3 (591)	Gás	68,1	264,00	264,00	264,00	326,8	326,8	326,8	590,8	590,8	590,8				590,8	590,8	590,8
MARANHAO3 (519)	Gás	85,0	490,0	490,0	490,0	0,0	25,8	23,0	490,0	515,8	513,0				490,0	515,8	513,0
MARANHAO V (338)	Gás	136,2				325,0	336,3	335,1	325,0	336,3	335,1				325,0	336,3	335,1
MARANHAOIV (338)	Gás	136,2				325,0	336,3	335,1	325,0	336,3	335,1				325,0	336,3	335,1
PARNAIB_IV (56)	Gás	151,7				56,3	56,3	56,3	56,3	56,3	56,3				56,3	56,3	56,3
P. ITAQUI (360)	Carvão	173,8				360,1	360,1	360,1	360,1	360,1	360,1				360,1	360,1	360,1
N.VENECIA2 (270)	Gás	230,3															
GERAMAR1 (166)	Óleo	611,6															
GERAMAR2 (166)	Óleo	611,6															
TOTAL NORTE (3356)			1148,5	1148,5	1148,5	1451,4	1495,8	1478,5	2599,9	2644,3	2627,0	0,0	0,0	0,0	2599,9	2644,3	2627,0

O conteúdo desta publicação foi produzido pelo ONS com base em dados e informações de conhecimento público. É de responsabilidade exclusiva dos agentes e demais interessados a obtenção de outros dados e informações, a realização de análises, estudos e avaliações para fins de tomada de decisões, definição de estratégias de atuação, assunção de compromissos e obrigações e quaisquer outras finalidades, em qualquer tempo e sob qualquer condição. É proibida a reprodução ou utilização total ou parcial do presente sem a identificação da fonte.