1. APRESENTAÇÃO

Na semana de 14/05 a 20/05/2022 ocorreu precipitação em pontos isolados das bacias dos rios Jacuí, Uruguai, Iguaçu, Paranapanema, Grande e da incremental a UHE Itaipu. Na região Norte, a condição de pancadas de chuva permaneceu nos trechos baixos das bacias dos rios Tocantins, Xingu, Tapajós e Madeira.

Na semana de 21/05 a 27/05/2022 há previsão de precipitação restrita ao extremo norte do Brasil e às bacias dos rios Jacuí, Uruguai, Iguaçu e na incremental a UHE Itaipu no final da semana operativa.

Para a semana operativa de 21/05 a 27/05/2022, houve oferta de energia da República Oriental do Uruguai. De acordo com o Art. 2º da Portaria MME nº 339, de 15 de agosto de 2018, as ofertas para importação de energia não foram consideradas na elaboração do PMO. Para a referida semana, não houve oferta de energia da República da Argentina.

Os valores médios semanais do Custo Marginal de Operação – CMO dos subsistemas do SIN sofreram as seguintes alterações em relação à semana anterior:

- SE/CO: de R$ 40,92/MWh para R$ 42,28/MWh
- Sul: de R$ 40,92/MWh para R$ 42,28/MWh
- Nordeste: de R$ 40,92/MWh para R$ 42,28/MWh
- Norte: de R$ 40,92/MWh para R$ 42,28/MWh

Desde o dia 01/01/2020, o despacho por ordem de mérito é indicado diariamente pelos resultados do modelo DESSEM. Assim, o despacho por ordem de mérito semanal, conforme publicado nesse documento, tem caráter apenas informativo. Da mesma forma, desde o dia 01/01/2021, a formação de preço deixou o formato semanal/patamar de carga e passou a ser horário, de acordo também com os resultados do modelo DESSEM.

2. NOTÍCIAS

Nos dias 26 e 27 de maio será realizada a reunião de elaboração do PMO de Junho de 2022, com transmissão ao vivo através do site do ONS.

3. ANÁLISE DAS CONDIÇÕES HIDROMETEOROLÓGICAS

3.1. PREVISÃO PARA A PRÓXIMA SEMANA

O céu claro predomina nas bacias hidrográficas do SIN, com previsão de precipitação restrita ao extremo norte do Brasil e às bacias dos rios Jacuí, Uruguai, Iguaçu e na incremental a UHE Itaipu no final da semana operativa (**Figura 1**).

O conteúdo desta publicação foi produzido pelo ONS com base em dados e informações de conhecimento público. É de responsabilidade exclusiva dos agentes e demais interessados a obtenção de outros dados e informações, a realização de análises, estudos e avaliações para fins de tomada de decisões, definição de estratégias de atuação, assunção de compromissos e obrigações e quaisquer outras finalidades, em qualquer tempo e sob qualquer condição. É proibida a reprodução ou utilização total ou parcial do presente sem a identificação da fonte.

Figura 1 - Precipitação acumulada prevista pelo modelo ECMWF - 21 a 27/05/2022

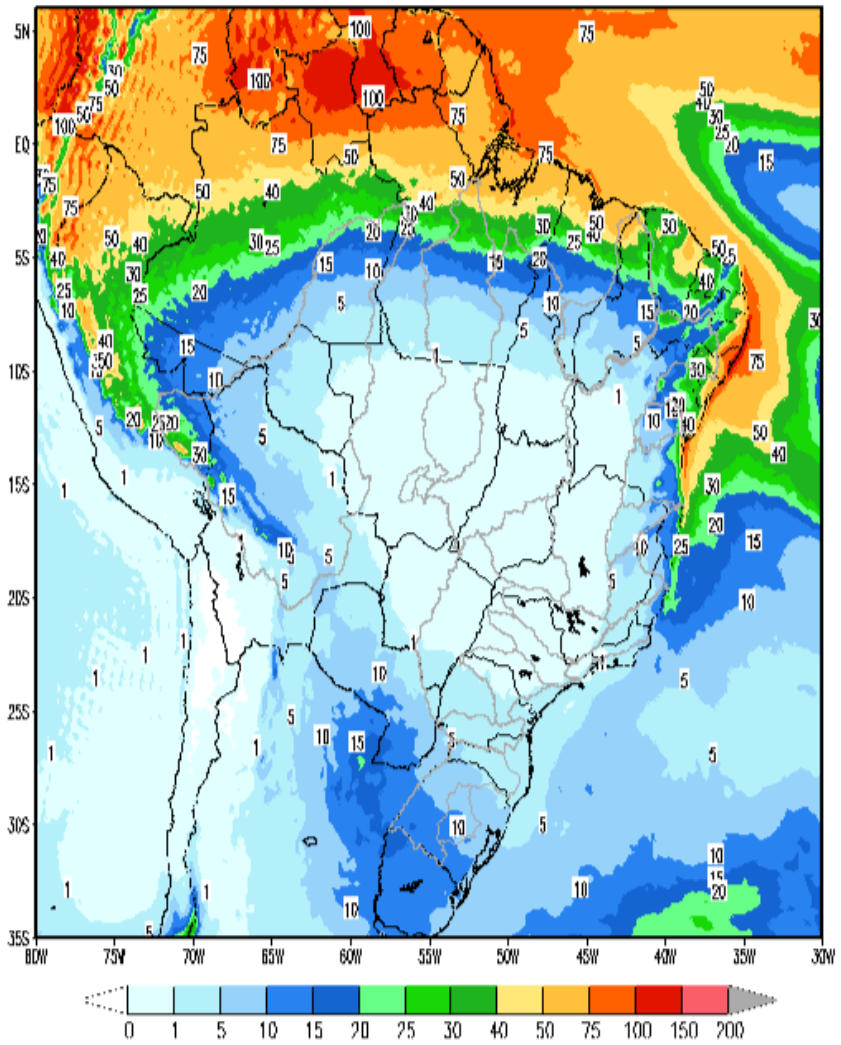

Em comparação com os valores estimados para a semana em curso, prevê-se para a próxima semana operativa ascensão nas afluências do subsistema nordeste e recessão nas afluências dos subsistemas Sudeste, Sul e Norte. A previsão mensal para maio indica a ocorrência de afluências abaixo da média histórica para os subsistemas Sudeste, Nordeste e Norte e acima da média histórica para o subsistema Sul.

Tabela 1 – Previsão de ENAs da revisão 3 de maio/2022

Revisão 3 do PMO de Maio/2022 - ENAs previstas				
Subsistema	21/05 a 27/05/2022		Mês de maio	
	MWmed	%MLT	MWmed	%MLT
SE/CO	24.236	61	26.389	66
S	6.687	79	16.088	189
NE	3.571	51	3.668	52
N	13.695	67	16.786	82

O conteúdo desta publicação foi produzido pelo ONS com base em dados e informações de conhecimento público. É de responsabilidade exclusiva dos agentes e demais interessados a obtenção de outros dados e informações, a realização de análises, estudos e avaliações para fins de tomada de decisões, definição de estratégias de atuação, assunção de compromissos e obrigações e quaisquer outras finalidades, em qualquer tempo e sob qualquer condição. É proibida a reprodução ou utilização total ou parcial do presente sem a identificação da fonte.

4. PREVISÃO DE CARGA

Um amplo conjunto de fatores, tem motivado a alta da confiança de diversos setores da economia. A percepção de controle sobre a crise sanitária, redução de IPI, liberação de recursos do FGTS e adiantamento do 13° de aposentados e pensionistas são alguns deles. Segundo divulgação da FGV em abril/22, mesmo após recuperar, no último bimestre, cerca de 1/3 das perdas ocorridas entre agosto de 2021 e fevereiro de 2022 a confiança empresarial continua moderadamente baixa e no caso dos consumidores, apesar da alta mais expressiva no mês de abril, o nível de confiança também vem se mantendo muito baixo desde o início da pandemia. Quanto ao setor serviços, observa-se desde março/22, uma elevação da confiança nos principais segmentos do setor, com destaque para os Serviços Prestados às Famílias e Outros Serviços. Ressalta-se que entre dezembro de 2021 e fevereiro de 2022, houve queda da confiança do Setor de Serviços provocado pelo aumento dos casos de COVID provocados pela variante Ômicron.

As sinalizações meteorológicas indicam para a próxima semana operativa, ocorrência de temperaturas máximas amenas, porém superiores às observadas na semana em curso nas capitais dos subsistemas Sudeste/Centro-Oeste e Sul. Destaca-se nessas capitais a manutenção das temperaturas mínimas em patamares mais baixos, semelhantes ao observado na semana em curso.

As capitais dos subsistemas Nordeste e Norte seguem com manutenção do comportamento observado nas últimas semanas, com registro de temperaturas elevadas e ocorrência de chuva em todos os dias. Ressalta-se os maiores totais de precipitação previstos para Recife e Belém.

Para o mês de maio/22 é previsto uma taxa de crescimento de 3,1% para o subsistema Nordeste, em relação ao mesmo mês do ano anterior. Para os subsistemas Sudeste/Centro-Oeste, Sul e Norte, são esperadas taxas de crescimento negativas de 1,5%, 2,2% e 0,1%, em relação a igual período do ano anterior. Ressalta-se no subsistema Norte que essa taxa essa variação negativa encontra-se influenciada pela redução parcial da carga de um consumidor livre da rede básica desde o mês de março do ano em curso.

Tabela 2 – Evolução da carga do PMO de Maio 2022

Subsistema	CARGA SEMANAL (MWmed)					CARGA MENSAL (MWmed)	
	1ª Sem	2ª Sem	3ª Sem	4ª Sem	5ª Sem	mai/22	Var. (%) mai/22 -> mai/21
SE/CO	41.025	39.012	37.341	37.724	37.566	38.547	-1,5%
Sul	11.412	11.029	11.386	11.334	11.361	11.295	-2,2%
Nordeste	11.157	11.107	11.483	11.235	11.216	11.245	3,1%
Norte	5.913	6.093	6.041	6.036	6.019	6.024	-0,1%
SIN	**69.507**	**67.241**	**66.251**	**66.329**	**66.162**	**67.111**	**-0,7%**

O conteúdo desta publicação foi produzido pelo ONS com base em dados e informações de conhecimento público. É de responsabilidade exclusiva dos agentes e demais interessados a obtenção de outros dados e informações, a realização de análises, estudos e avaliações para fins de tomada de decisões, definição de estratégias de atuação, assunção de compromissos e obrigações e quaisquer outras finalidades, em qualquer tempo e sob qualquer condição. É proibida a reprodução ou utilização total ou parcial do presente sem a identificação da fonte.

5. PRINCIPAIS RESULTADOS

5.1. CUSTO MARGINAL DE OPERAÇÃO (CMO)

A tabela a seguir apresenta o CMO, por subsistema e patamar de carga para próxima semana operativa.

Tabela 3 – CMO por patamar de carga

Patamares de Carga	CMO (R$/MWh)			
	SE/CO	S	NE	N
Pesada	42,62	42,62	42,62	42,62
Média	42,44	42,44	42,44	42,44
Leve	41,93	41,93	41,93	41,93
Média Semanal	42,28	42,28	42,28	42,28

Na figura a seguir é apresentada a evolução do CMO médio semanal ao longo deste PMO.

Figura 2 – Evolução semanal do CMO

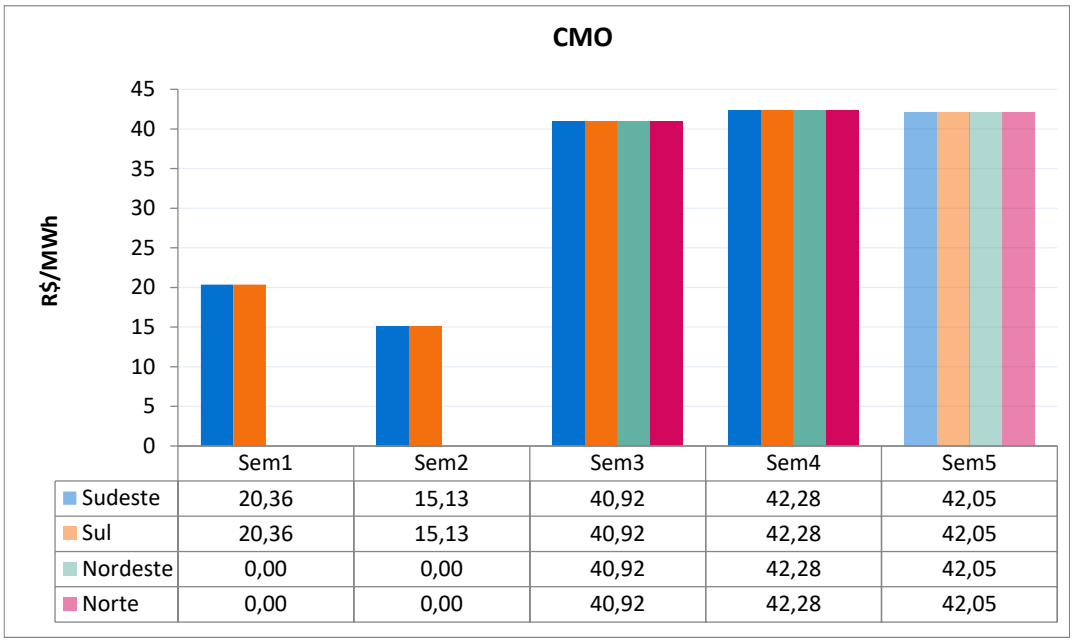

5.2. POLÍTICA DE OPERAÇÃO ENERGÉTICA

Para esta semana operativa, está prevista a seguinte política de intercâmbio de energia entre regiões:

Região SE/CO → Geração hidráulica visando a preservação dos armazenamentos.

Região Sul → Geração de acordo com os condicionantes hidráulicos e controlando o intercâmbio SE/CO-Sul, para evitar vertimentos.

Região NE → Manutenção da exploração das disponibilidades energéticas, maximização da exportação para SE/CO, respeitando-se as restrições hidráulicas e os limites elétricos vigentes.

Região Norte → Exploração das disponibilidades energéticas, maximização da exportação para SE/CO, respeitando-se os limites elétricos vigentes.

O conteúdo desta publicação foi produzido pelo ONS com base em dados e informações de conhecimento público. É de responsabilidade exclusiva dos agentes e demais interessados a obtenção de outros dados e informações, a realização de análises, estudos e avaliações para fins de tomada de decisões, definição de estratégias de atuação, assunção de compromissos e obrigações e quaisquer outras finalidades, em qualquer tempo e sob qualquer condição. É proibida a reprodução ou utilização total ou parcial do presente sem a identificação da fonte.

6. ANÁLISE DA VARIAÇÃO SEMANAL DO CMO

Esta análise visa identificar os principais parâmetros cujas atualizações impactaram os CMO deste PMO, em comparação com os valores obtidos na última revisão.

Foram realizados 8 estudos, onde o caso inicial foi construído com base nos dados oficiais da última revisão deste PMO. Neste primeiro estudo, denominado de "previsão perfeita", a partida dos reservatórios foi estimada conforme indicado para esta semana na última revisão.

O segundo estudo foi realizado com os dados do caso inicial sendo substituída a previsão de vazões.

A partir do conjunto de dados do segundo estudo foram elaborados os demais casos em que foram atualizadas, sequencialmente, as seguintes informações: níveis de partida dos reservatórios, previsão de carga, disponibilidade das usinas térmicas e hidráulicas, restrições de limites de intercâmbio, restrições hidráulicas e, por fim, os demais dados que compõem toda informação referente a atual revisão.

Os custos marginais de operação dos quatro subsistemas que compõem o SIN permanecem acoplados nesta semana operativa. A Figura 3 apresenta a análise de variação dos CMO dos subsistemas Sudeste/Centro-Oeste, Sul, Nordeste e Norte em relação à semana passada.

Conforme pode ser observado, era esperada a elevação dos CMO tendo em vista os níveis dos reservatórios indicados na simulação da semana passada. Entretanto, a atualização das restrições hidráulicas reduziu o impacto desta elevação, fazendo com que os CMO do SIN não tivessem variação significativa em relação aos da Revisão 2 do PMO de Maio.

Figura 3 – Análise da variação do CMO dos subsistemas do SIN

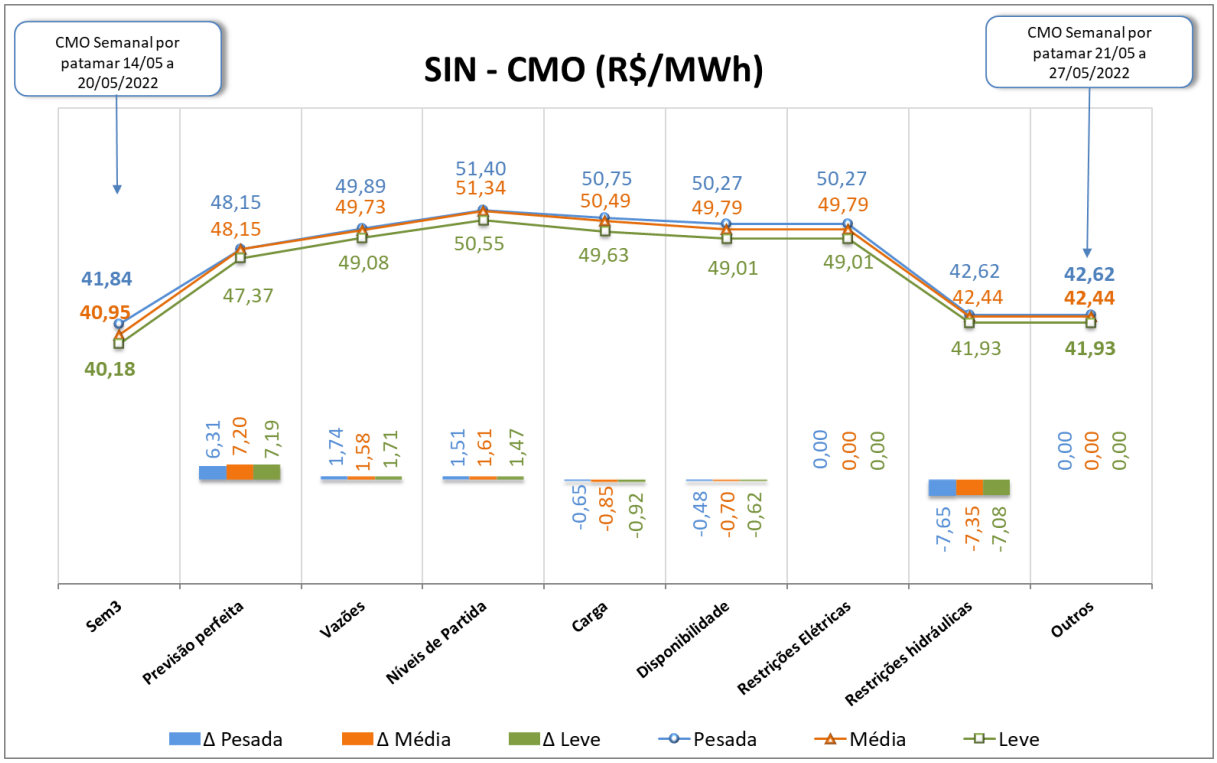

O conteúdo desta publicação foi produzido pelo ONS com base em dados e informações de conhecimento público. É de responsabilidade exclusiva dos agentes e demais interessados a obtenção de outros dados e informações, a realização de análises, estudos e avaliações para fins de tomada de decisões, definição de estratégias de atuação, assunção de compromissos e obrigações e quaisquer outras finalidades, em qualquer tempo e sob qualquer condição. É proibida a reprodução ou utilização total ou parcial do presente sem a identificação da fonte.

7. GERAÇÃO TÉRMICA

A Figura 4 apresenta, para cada subsistema, o despacho térmico por modalidade indicado pelo Decomp para a próxima semana operativa.

Figura 4 – Geração térmica para a próxima semana operativa

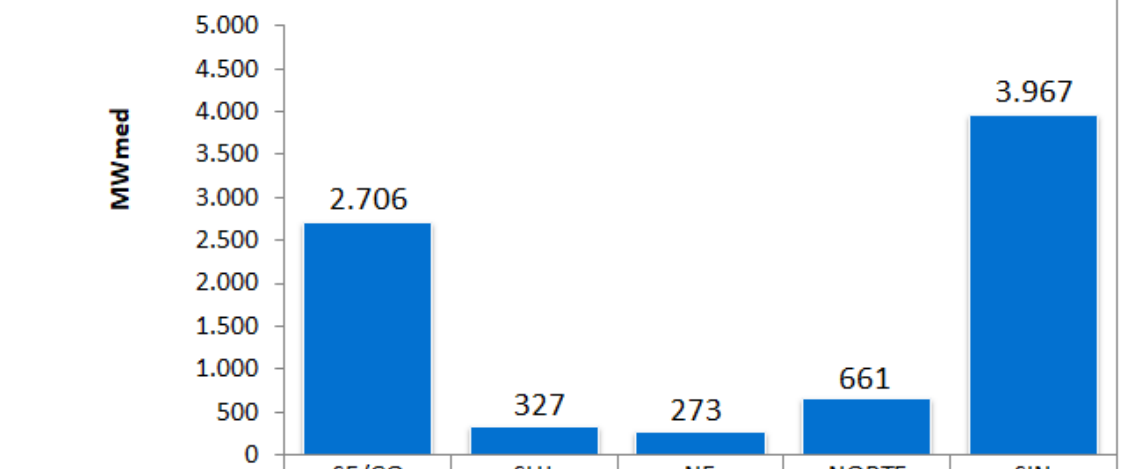

	SE/CO	SUL	NE	NORTE	SIN
RESTRIÇÃO ELÉTRICA	0	0	0	0	0
INFLEXIBILIDADE	2706	327	273	661	3967
ORDEM DE MÉRITO	0	0	0	0	0

Na tabela abaixo segue a Indicação de despacho antecipado por ordem de mérito de custo para a semana de 23/07/2022 a 29/07/2022.

Tabela 4 – UTEs com contrato de combustível GNL

UTE			Benefício (R$/MWh)		
Nome	Cod	CVU (R$/MWh)	Carga Pesada	Carga Média	Carga Leve
SANTA CRUZ	86	423,75	53,92 (2)	53,92 (2)	53,90 (2)
LUIZORMELO	15	659,54	53,92 (2)	53,92 (2)	53,90 (2)
PSERGIPE I	224	406,24	53,77 (2)	53,29 (2)	53,28 (2)

(1) Comandado o despacho antecipado por ordem de mérito de custo nesse patamar

(2) NÃO foi comandado o despacho antecipado por ordem de mérito de custo nesse patamar

Assim sendo, não há previsão de despacho antecipado por ordem de mérito de custo para as UTE Santa Cruz, Luiz O. R. Melo e Porto Sergipe I, para a semana de 23/07 a 29/07/2022.

O conteúdo desta publicação foi produzido pelo ONS com base em dados e informações de conhecimento público. É de responsabilidade exclusiva dos agentes e demais interessados a obtenção de outros dados e informações, a realização de análises, estudos e avaliações para fins de tomada de decisões, definição de estratégias de atuação, assunção de compromissos e obrigações e quaisquer outras finalidades, em qualquer tempo e sob qualquer condição. É proibida a reprodução ou utilização total ou parcial do presente sem a identificação da fonte.

8. IMPORTAÇÃO DE ENERGIA DA REPÚBLICA ORIENTAL DO URUGUAI

8.1. República Oriental do Uruguai

Para a próxima semana operativa, foram declaradas as seguintes ofertas de importação de energia da República Oriental do Uruguai para o Sistema Interligado Nacional - SIN através da conversora de Melo (500 MW).

- **Enel**

Tabela 5 – Energia ofertada para importação

	Oferta de Energia para a Semana de 21/05 a 27/05 (MWmed)						
	Bloco 1	Bloco 2	Bloco 3	Bloco 4	Bloco 5	Bloco 6	Total
Carga Pesada	50	50	50	50	25	25	250
Carga Média	50	50	50	50	25	25	250
Carga Leve	50	50	50	50	25	25	250
CVU (R$/MWh)	495,99	704,47	1.299,92	1.468,33	2.009,65	2.358,50	

- **BTG Pactual**

Tabela 6 – Energia ofertada para importação

	Oferta de Energia para a Semana de 21/05 a 27/05 (MWmed)						
	Bloco 1	Bloco 2	Bloco 3	Bloco 4	Bloco 5	Bloco 6	Total
Carga Pesada	50	50	50	50	25	25	250
Carga Média	50	50	50	50	25	25	250
Carga Leve	50	50	50	50	25	25	250
CVU (R$/MWh)	500,51	713,72	1.316,80	1.487,37	2.035,62	2.388,94	

8.2. República da Argentina

Para esta semana operativa, não houve oferta de importação de energia da República da Argentina.

Nota: Detalhes sobre a importação de energia vide Portaria Nº 339, de 15 de agosto de 2018 disponível em: http://pesquisa.in.gov.br/imprensa/jsp/visualiza/index.jsp?data=17/08/2018&jornal=515&pagina=60&totalArquivos=136

O conteúdo desta publicação foi produzido pelo ONS com base em dados e informações de conhecimento público. É de responsabilidade exclusiva dos agentes e demais interessados a obtenção de outros dados e informações, a realização de análises, estudos e avaliações para fins de tomada de decisões, definição de estratégias de atuação, assunção de compromissos e obrigações e quaisquer outras finalidades, em qualquer tempo e sob qualquer condição. É proibida a reprodução ou utilização total ou parcial do presente sem a identificação da fonte.

9. ARMAZENAMENTOS OPERATIVOS

Para uma melhor avaliação de diversos cenários hidrometeorológicos, notadamente, aqueles de curto prazo e suas influências nas previsões de vazões nos subsistemas, os resultados desta revisão do PMO contemplam cenários de afluências visando melhor representar a ocorrência de precipitação e, consequentemente, seus efeitos sobre as afluências e armazenamentos.

Além dos resultados associados ao valor esperado das previsões de afluências, as simulações operativas também foram realizadas com os limites superior e inferior das previsões de afluências. Apresentamos a seguir as correspondentes energias naturais afluentes e os resultados obtidos com a aplicação dos diferentes cenários de afluência.

Tabela 7 – Previsão de ENA dos cenários de sensibilidade

Subsistema	ENERGIAS NATURAIS AFLUENTES					
	Previsão Mensal					
	LI		VE		LS	
	(MWmed)	%MLT	(MWmed)	%MLT	(MWmed)	%MLT
SE/CO	25.204	**63**	26.389	**66**	27.554	**69**
Sul	14.872	**175**	16.088	**189**	17.298	**204**
Nordeste	3.556	**51**	3.668	**52**	3.781	**54**
Norte	16.243	**80**	16.786	**82**	17.329	**85**

Tabela 8 – Previsão de %EARmáx para o final do mês

Subsistema	% EARmáx 20/05	% EARmáx - 31/05		
	NÍVEL INICIAL	NÍVEL PMO		
	VE	LI	VE	LS
SE/CO	66,6	65,8	66,6	67,4
Sul	88,6	76,8	82,2	86,7
Nordeste	95,0	94,2	94,4	94,5
Norte	99,3	99,7	99,3	99,2

O conteúdo desta publicação foi produzido pelo ONS com base em dados e informações de conhecimento público. É de responsabilidade exclusiva dos agentes e demais interessados a obtenção de outros dados e informações, a realização de análises, estudos e avaliações para fins de tomada de decisões, definição de estratégias de atuação, assunção de compromissos e obrigações e quaisquer outras finalidades, em qualquer tempo e sob qualquer condição. É proibida a reprodução ou utilização total ou parcial do presente sem a identificação da fonte.

10. RESERVATÓRIOS EQUIVALENTES DE ENERGIA

A seguir são apresentadas as previsões de Energia Natural Afluente para a próxima semana operativa e para o mês de maio, bem como as previsões de Energia Armazenada nos Reservatórios Equivalentes de Energia – REE, desta revisão do PMO.

Tabela 9 – Previsão de ENA por REE

Valor Esperado das Energias Naturais Afluentes				
REE	Previsão Semanal		Previsão Mensal	
	21/05/2022 a 27/05/2022		mai/22	
	(MWmed)	%MLT	(MWmed)	%MLT
Sudeste	3.187	69	3.609	78
Madeira	4.181	47	4.837	54
Teles Pires	1.463	69	1.822	86
Itaipu	2.699	77	2.901	83
Paraná	11.122	60	11.394	61
Paranapanema	875	38	1.009	43
Sul	3.620	82	10.876	248
Iguaçu	3.068	75	5.213	127
Nordeste	3.571	51	3.668	52
Norte	4.883	53	6.481	70
Belo Monte	5.924	63	8.154	87
Manaus	2.901	171	2.564	151

Tabela 10 – Previsão de %EARmáx por REE

% Energia Armazenável Máxima		
REE	Previsão Semanal	Previsão Mensal
	27-mai	31-mai
	(%EARmáx)	(%EARmáx)
Sudeste	65,0	64,5
Madeira	97,9	99,1
Teles Pires	90,6	93,4
Itaipu	95,4	98,0
Paraná	68,4	68,4
Paranapanema	49,5	49,5
Sul	75,4	72,9
Iguaçu	93,3	90,7
Nordeste	94,6	94,4
Norte	100,0	100,0
Belo Monte	100,0	100,0
Manaus	84,6	87,3

O conteúdo desta publicação foi produzido pelo ONS com base em dados e informações de conhecimento público. É de responsabilidade exclusiva dos agentes e demais interessados a obtenção de outros dados e informações, a realização de análises, estudos e avaliações para fins de tomada de decisões, definição de estratégias de atuação, assunção de compromissos e obrigações e quaisquer outras finalidades, em qualquer tempo e sob qualquer condição. É proibida a reprodução ou utilização total ou parcial do presente sem a identificação da fonte.

11. DESPACHO TÉRMICO POR MODALIDADE, PATAMAR DE CARGA E USINA

Nas tabelas abaixo, a diferenciação entre geração por inflexibilidade e por ordem de mérito tem caráter informativo, com o objetivo de detalhar a informação de inflexibilidade enviada pelos respectivos agentes para esta revisão do PMO. Ressalta-se que nas etapas de Programação Diária e Tempo Real, o montante despachado nas usinas termelétricas indicadas por ordem de mérito é plenamente intitulado como ordem de mérito.

REGIÃO SUDESTE/CENTRO-OESTE																	
Térmicas Potência (MW)	Combustível	CVU (R$/MWh)	Inflexibilidade			Ordem de Mérito			Total Mérito e INFL.			Razão Elétrica			Total UTE		
			P	M	L	P	M	L	P	M	L	P	M	L	P	M	L
ATLAN_CSA (255)	Resíduos	0,00	17,0	17,0	17,0				17,0	17,0	17,0				17,0	17,0	17,0
W.ARJONA* (177)	Gás	---															
W.ARJONA O* (177)	Diesel	---															
ANGRA 2 (1350)	Nuclear	20,12	1350,0	1350,0	1350,0	0,0	0,0	0,0	1350,0	1350,0	1350,0				1350,0	1350,0	1350,0
ANGRA 1 (640)	Nuclear	31,17	640,0	640,0	640,0	0,0	0,0	0,0	640,0	640,0	640,0				640,0	640,0	640,0
NORTEFLU 1 (400)	Gás	93,44															
NORTEFLU 2 (100)	Gás	109,68															
O.PINTADA (50)	Biomassa	124,48															
UTE STA VI (41)	Biomassa	134,46	14,0	14,0	14,0				14,0	14,0	14,0				14,0	14,0	14,0
PREDILECTA (5)	Biomassa	175,91															
NORTEFLU 3 (200)	Gás	208,88															
ATLANTICO (235)	Resíduos	217,58	218,7	218,7	218,7				218,7	218,7	218,7				218,7	218,7	218,7
ST.CRUZ 34 (436)	Óleo	310,41															
T.LAGOAS (350)	Gás	317,11															
CUBATAO (216)	Gás	375,13	50,0	50,0	50,0				50,0	50,0	50,0				50,0	50,0	50,0
TERMORIO (989)	Gás	377,58	65,0	65,0	65,0				65,0	65,0	65,0				65,0	65,0	65,0
BAIXADA FL (530)	Gás	418,60															
SANTA CRUZ (500)	GNL	423,75															
SEROPEDICA (360)	Gás	466,08															
PIRAT.12 O (200)	Gás	470,34															
JUIZ DE FO (87)	Gás	522,96															
NPIRATINGA (572)	Gás	654,42															
LUIZORMELO (204)	GNL	659,54															
NORTEFLU 4 (127)	Gás	794,07															
UTE GNA I (1338)	Gás	829,74															
T.MACAE (929)	Gás	882,21															
TNORTE 2 (349)	Óleo	910,86															
CAMPOS (25)	Gás	978,10															
VIANA (175)	Óleo	1242,55															
IBIRITE (226)	Gás	1422,00															
PALMEIR_GO (176)	Diesel	1493,88															
DAIA (44)	Diesel	1828,50															
GOIANIA 2 (140)	Diesel	1928,84															
CUIABA CC (529)	Gás	2039,96	351,0	351,0	351,0				351,0	351,0	351,0				351,0	351,0	351,0
XAVANTES (54)	Diesel	2633,27															
TOTAL SE/CO (12009)			2705,7	2705,7	2705,7	0,0	0,0	0,0	2705,7	2705,7	2705,7	0,0	0,0	0,0	2705,7	2705,7	2705,7

REGIÃO SUL																	
Térmicas Potência (MW)	Combustível	CVU (R$/MWh)	Inflexibilidade			Ordem de Mérito			Total Mérito e INFL.			Razão Elétrica			Total UTE		
			P	M	L	P	M	L	P	M	L	P	M	L	P	M	L
ARAUCARIA (484)	Gás	0,00															
URUGUAIANA (640)	Gás	---															
PAMPA SUL (345)	Carvão	77,19															
SAO SEPE (8)	Biomassa	97,11	5,0	5,0	5,0				5,0	5,0	5,0				5,0	5,0	5,0
CANDIOTA_3 (350)	Carvão	97,20	320,0	320,0	320,0				320,0	320,0	320,0				320,0	320,0	320,0
J.LACER. C (363)	Carvão	229,27															
J.LACER. B (262)	Carvão	271,21															
J.LAC. A2 (132)	Carvão	278,38															
J.LAC. A1 (100)	Carvão	304,61															
MADEIRA (4)	Biomassa	350,47	2,0	2,0	2,0				2,0	2,0	2,0				2,0	2,0	2,0
FIGUEIRA (20)	Carvão	475,68															
CANOAS (249)	Diesel	698,14															
TOTAL SUL (2957)			327,0	327,0	327,0	0,0	0,0	0,0	327,0	327,0	327,0	0,0	0,0	0,0	327,0	327,0	327,0

*Conforme Resolução Autorizativa ANEEL nº 10.422/2021, a UTE William Arjona pode operar com óleo diesel, como combustível alternativo.

O conteúdo desta publicação foi produzido pelo ONS com base em dados e informações de conhecimento público. É de responsabilidade exclusiva dos agentes e demais interessados a obtenção de outros dados e informações, a realização de análises, estudos e avaliações para fins de tomada de decisões, definição de estratégias de atuação, assunção de compromissos e obrigações e quaisquer outras finalidades, em qualquer tempo e sob qualquer condição. É proibida a reprodução ou utilização total ou parcial do presente sem a identificação da fonte.

REGIÃO NORDESTE																	
Térmicas Potência (MW)	Combustível	CVU (R$/MWh)	Inflexibilidade			Ordem de Mérito			Total Mérito e INFL.			Razão Elétrica			Total UTE		
			P	M	L	P	M	L	P	M	L	P	M	L	P	M	L
ALTOS (13)	Diesel	---															
ARACATI (11)	Diesel	---															
BATURITE (11)	Diesel	---															
C.MAIOR (13)	Diesel	---															
CAUCAIA (15)	Diesel	---															
CRATO (13)	Diesel	---															
IGUATU (15)	Diesel	---															
JUAZEIRO N (15)	Diesel	---															
MARAMBAIA (13)	Diesel	---															
NAZARIA (13)	Diesel	---															
PECEM (15)	Diesel	---															
ERB CANDEI (17)	Biomassa	97,18	4,5	4,5	4,5				4,5	4,5	4,5				4,5	4,5	4,5
PROSPERIDA (28)	Gás	183,28															
TERMOPE (533)	Gás	191,01															
FORTALEZA (327)	Gás	254,96															
T.BAHIA (186)	Gás	374,87	158,9	158,9	158,9				158,9	158,9	158,9				158,9	158,9	158,9
PSERGIPE I (1593)	GNL	406,24															
VALE ACU (368)	Gás	450,86	110,0	110,0	110,0				110,0	110,0	110,0				110,0	110,0	110,0
TERMOCEARA (223)	Gás	475,79															
SYKUE I (30)	Biomassa	510,12															
P.PECEM2 (365)	Carvão	830,65															
P.PECEM1 (720)	Carvão	853,99															
PERNAMBU_3 (201)	Óleo	1076,84															
MARACANAU (168)	Óleo	1212,01															
TERMOCABO (50)	Óleo	1227,16															
TERMONE (171)	Óleo	1229,40															
TERMOPB (171)	Óleo	1229,40															
CAMPINA_GR (169)	Óleo	1242,57															
SUAPE II (381)	Óleo	1278,66															
GLOBAL I (149)	Óleo	1406,96															
GLOBAL II (149)	Óleo	1406,96															
CURUMIM (31)	Óleo	1492,19															
APOENA (147)	Óleo	1837,58															
GUARANI (150)	Óleo	1837,58															
PETROLINA (136)	Óleo	2016,07															
POTIGUAR_3 (66)	Diesel	2032,71															
POTIGUAR (53)	Diesel	2032,73															
PAU FERRO (94)	Diesel	2277,09															
TERMOMANAU (143)	Diesel	2277,09															
TOTAL NE (6966)			273,4	273,4	273,4	0,0	0,0	0,0	273,4	273,4	273,4	0,0	0,0	0,0	273,4	273,4	273,4

REGIÃO NORTE																	
Térmicas Potência (MW)	Combustível	CVU (R$/MWh)	Inflexibilidade			Ordem de Mérito			Total Mérito e INFL.			Razão Elétrica			Total UTE		
			P	M	L	P	M	L	P	M	L	P	M	L	P	M	L
C. ROCHA (85)	Gás	0,00	65,0	65,0	65,0				65,0	65,0	65,0				65,0	65,0	65,0
JARAQUI (75)	Gás	0,00	63,0	63,0	63,0				63,0	63,0	63,0				63,0	63,0	63,0
MANAUARA (67)	Gás	0,00	64,0	64,0	64,0				64,0	64,0	64,0				64,0	64,0	64,0
PONTA NEGR (73)	Gás	0,00	64,0	64,0	64,0				64,0	64,0	64,0				64,0	64,0	64,0
TAMBAQUI (93)	Gás	0,00	63,0	63,0	63,0				63,0	63,0	63,0				63,0	63,0	63,0
MARANHAO3 (519)	Gás	94,86															
PARNAIB_IV (56)	Gás	151,69	3,0	3,0	3,0				3,0	3,0	3,0				3,0	3,0	3,0
APARECIDA (166)	Gás	183,51	75,0	75,0	75,0				75,0	75,0	75,0				75,0	75,0	75,0
UTE MAUA 3 (591)	Gás	183,51	264,0	264,0	264,0				264,0	264,0	264,0				264,0	264,0	264,0
N.VEN2_L22 (27)	Gás	257,06															
N.VEN2_L7 (151)	Gás	257,06															
MARAN_VL_7 (336)	Gás	386,90															
MARANIVL_7 (336)	Gás	386,90															
MARAN_VL22 (1)	Gás	386,91															
MARANIVL22 (1)	Gás	386,91															
P. ITAQUI (360)	Carvão	821,16															
GERAMAR1 (166)	Óleo	1242,53															
GERAMAR2 (166)	Óleo	1242,53															
TOTAL NORTE (3271)			661,0	661,0	661,0	0,0	0,0	0,0	661,0	661,0	661,0	0,0	0,0	0,0	661,0	661,0	661,0

O conteúdo desta publicação foi produzido pelo ONS com base em dados e informações de conhecimento público. É de responsabilidade exclusiva dos agentes e demais interessados a obtenção de outros dados e informações, a realização de análises, estudos e avaliações para fins de tomada de decisões, definição de estratégias de atuação, assunção de compromissos e obrigações e quaisquer outras finalidades, em qualquer tempo e sob qualquer condição. É proibida a reprodução ou utilização total ou parcial do presente sem a identificação da fonte.