1. APRESENTAÇÃO

No mês de novembro, observou-se precipitação abaixo da média em todas as bacias localizadas nas regiões Sul e Sudeste, enquanto nas regiões Norte e Nordeste ocorreu precipitação acima da média no trecho entre as UHEs Três Marias e Sobradinho, na bacia do rio São Francisco, e próximo da média histórica na bacia do rio Tocantins.

Na semana de 26/11 a 02/11/2022 deve ocorrer chuva fraca a moderada nas bacias dos rios Paraíba do Sul, São Francisco, Tocantins e Xingu. As demais bacias de interesse para o SIN apresentam chuva fraca.

Para a semana operativa de 26/11 a 02/11/2022, houve oferta de energia da República Oriental do Uruguai. De acordo com o Art. 2º da Portaria MME nº 339, de 15 de agosto de 2018, as ofertas para importação de energia não foram consideradas na elaboração do PMO. Para a referida semana, não houve oferta de energia da República da Argentina.

Os valores médios semanais do Custo Marginal de Operação – CMO dos subsistemas do SIN sofreram as seguintes alterações em relação à semana anterior:

- SE/CO: de R$ 0,00/MWh para R$ 0,07/MWh
- Sul: de R$ 0,00/MWh para R$ 0,07/MWh
- Nordeste: de R$ 0,00/MWh para R$ 0,07/MWh
- Norte: de R$ 0,00/MWh para R$ 0,07/MWh

Desde o dia 01/01/2020, o despacho por ordem de mérito é indicado diariamente pelos resultados do modelo DESSEM. Assim, o despacho por ordem de mérito semanal, conforme publicado nesse documento, tem caráter apenas informativo. Da mesma forma, desde o dia 01/01/2021, a formação de preço deixou o formato semanal/patamar de carga e passou a ser horário, de acordo também com os resultados do modelo DESSEM.

2. NOTÍCIAS

Nos dias 29 e 30 de dezembro será realizada a reunião de elaboração do PMO de Janeiro de 2023, com transmissão ao vivo através do site do ONS.

3. INFORMAÇÕES PARA ESTUDOS ENERGÉTICOS DE MÉDIO PRAZO - CONSTRUÇÃO DA FUNÇÃO DE CUSTO FUTURO

A atualização de dados para os estudos energéticos de médio prazo é realizada mensalmente quando da elaboração do PMO, tendo por base as informações fornecidas pela ANEEL, MME, EPE, CCEE e Agentes, além de diversas áreas do ONS.

O conteúdo desta publicação foi produzido pelo ONS com base em dados e informações de conhecimento público. É de responsabilidade exclusiva dos agentes e demais interessados a obtenção de outros dados e informações, a realização de análises, estudos e avaliações para fins de tomada de decisões, definição de estratégias de atuação, assunção de compromissos e obrigações e quaisquer outras finalidades, em qualquer tempo e sob qualquer condição. É proibida a reprodução ou utilização total ou parcial do presente sem a identificação da fonte.

3.1. ATUALIZAÇÃO DAS INFORMAÇÕES ESTRUTURAIS

3.1.1. Oferta

Nas **Figura 1**, **Figura 2** e **Figura 3**, a seguir, são apresentadas as evoluções da oferta hidroelétrica, termoelétrica e da disponibilidade das usinas não simuladas individualmente, respectivamente, em comparação ao PMO de Novembro/2022, identificando eventuais atrasos ou antecipações de cronograma feitos na reunião de acompanhamento do Departamento de Monitoramento do Setor Elétrico – DMSE/MME, realizada em 17/11/2022.

Figura 1 - Evolução da potência instalada das UHEs

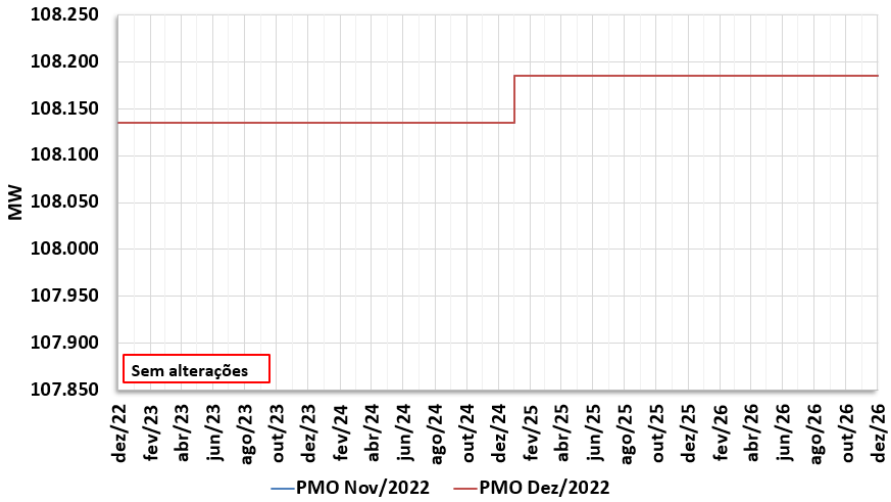

Figura 2 - Evolução da potência instalada das UTEs

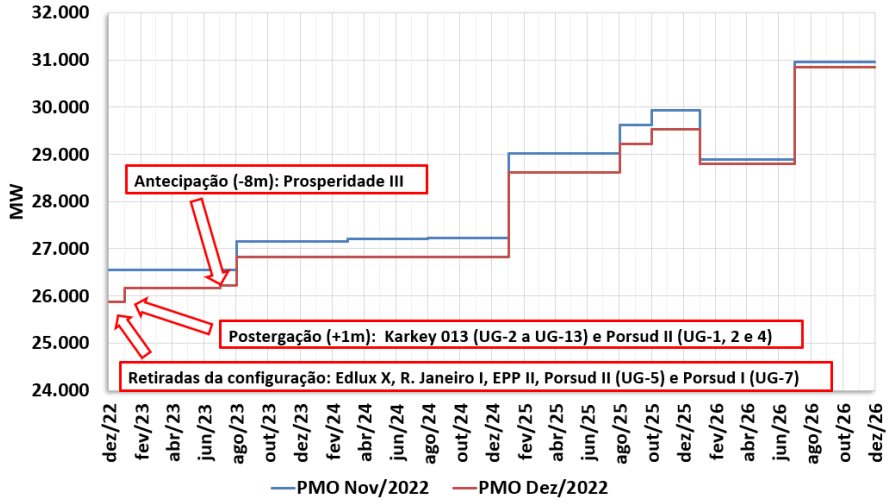

O conteúdo desta publicação foi produzido pelo ONS com base em dados e informações de conhecimento público. É de responsabilidade exclusiva dos agentes e demais interessados a obtenção de outros dados e informações, a realização de análises, estudos e avaliações para fins de tomada de decisões, definição de estratégias de atuação, assunção de compromissos e obrigações e quaisquer outras finalidades, em qualquer tempo e sob qualquer condição. É proibida a reprodução ou utilização total ou parcial do presente sem a identificação da fonte.

Figura 3 - Evolução da disponibilidade das usinas não simuladas

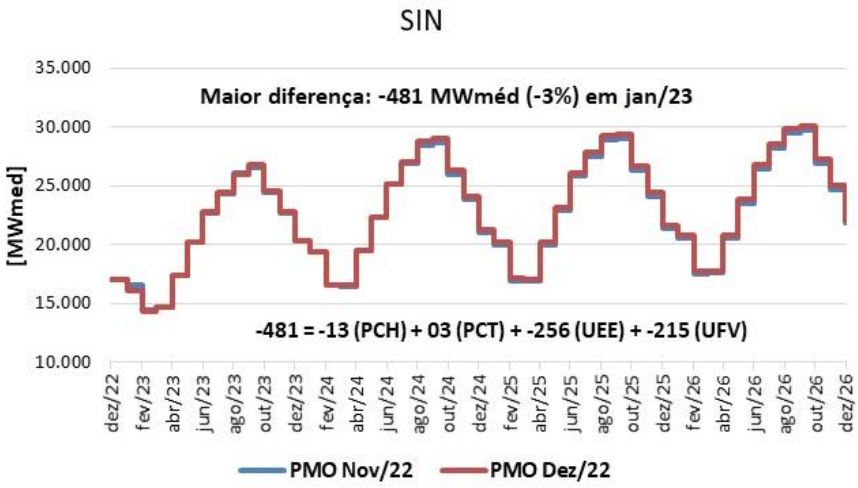

3.1.2. Armazenamentos Iniciais

Na **Figura 4**, a seguir, são apresentados os armazenamentos iniciais equivalentes por subsistema, considerados nos modelos de otimização para a elaboração do PMO de Dezembro/2022, comparados com os do PMO de Novembro/2022.

Figura 4 – Energia armazenada inicial em novembro/22 e dezembro/22

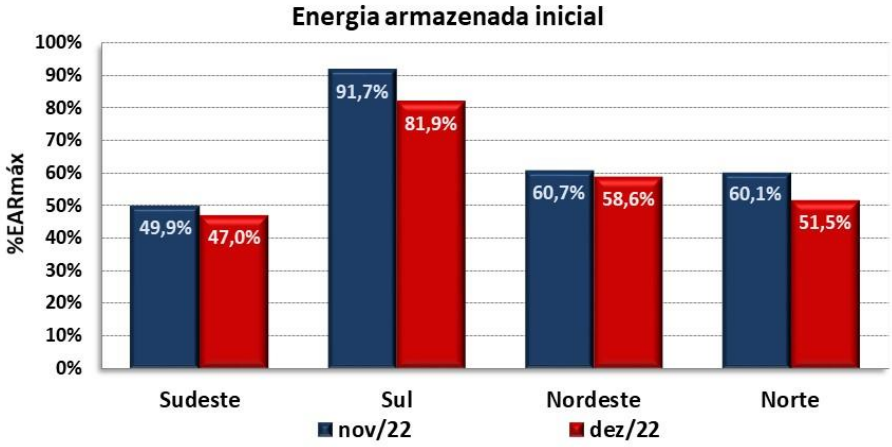

3.1.3. Tendência Hidrológica

Na **Tabela 1**, a seguir, são apresentadas as tendências hidrológicas consideradas pelo modelo NEWAVE para o PMO de Dezembro/2022, comparadas com o PMO de Novembro/2022.

O conteúdo desta publicação foi produzido pelo ONS com base em dados e informações de conhecimento público. É de responsabilidade exclusiva dos agentes e demais interessados a obtenção de outros dados e informações, a realização de análises, estudos e avaliações para fins de tomada de decisões, definição de estratégias de atuação, assunção de compromissos e obrigações e quaisquer outras finalidades, em qualquer tempo e sob qualquer condição. É proibida a reprodução ou utilização total ou parcial do presente sem a identificação da fonte.

Tabela 1 – Tendência hidrológica para o PMO de Dezembro/2022 – NEWAVE [%MLT]

	PMO novembro/2022				PMO dezembro/2022			
MÊS	SE/CO	S	NE	N	SE/CO	S	NE	N
mai/22	68	223	52	81				
jun/22	75	236	64	81	75	236	64	81
jul/22	66	70	69	86	66	70	69	86
ago/22	77	126	64	82	78	126	64	83
Set/22	82	83	68	78	82	83	68	78
Out/22	108	158	60	76	105	159	61	70
Nov/22					81	82	74	103

* ≥100% MLT < 100% MLT

3.2. DEMAIS ATUALIZAÇÕES

Adicionalmente, neste PMO ocorreram os seguintes destaques:

- Horizonte de estudo: dezembro de 2022 a dezembro de 2026;
- Cronograma de Obras – Reunião DMSE-G de 17/11/2022, com destaque para: Operação comercial da UTE Parnaíba V conforme Despacho SFG/ANEEL nº 3.269 de 12/11/2022; Antecipação da UTE Prosperidade III para jul/2023; Desconsideração das UTEs EPP II, R. Janeiro I, EDLUX X, UG7 da Porsud I e UG5 da Porsud II, que tiveram mudança de status para sem previsão;
- CVUs das UTEs vendedoras em leilão;
- CVU das UTEs NorteFluminense 1, 2, 3, 4 e Termopernambuco, conforme Despachos SRG/ANEEL nº 3.271/2022 e 3.276/2022;
- Alterações de restrições operativas para as UHEs Barra Grande e Chavantes de acordo com os FSAR-H enviados pelos Agentes responsáveis;
- Restrições de defluências das usinas do Rio São Francisco conforme "Informe Sobre o Planejamento e a Programação da Operação dos Aproveitamentos Hidroelétricos da Bacia do Rio São Francisco no PMO de dezembro de 2022";
- Restrições de defluência da UHE Serra da Mesa conforme "Informe Sobre o Planejamento e a Programação da Operação da Bacia do Rio Tocantins no PMO de dezembro de 2022";
- Limites de Intercâmbio com valores segundo Relatório Mensal de Limites de Intercâmbio RT-ONS DPL 0597/2022;
- Compatibilização da disponibilidade térmica para os dois primeiros meses de acordo com informação da programação mensal;
- Compatibilização dos valores dos 2 primeiros meses da geração hidráulica mínima das UHEs Itaipu e Tucuruí de acordo com os utilizados na programação mensal;
- Previsões de carga consolidada para os 2 primeiros meses.

O conteúdo desta publicação foi produzido pelo ONS com base em dados e informações de conhecimento público. É de responsabilidade exclusiva dos agentes e demais interessados a obtenção de outros dados e informações, a realização de análises, estudos e avaliações para fins de tomada de decisões, definição de estratégias de atuação, assunção de compromissos e obrigações e quaisquer outras finalidades, em qualquer tempo e sob qualquer condição. É proibida a reprodução ou utilização total ou parcial do presente sem a identificação da fonte.

4. ANÁLISE DAS CONDIÇÕES HIDROMETEOROLÓGICAS

No início da próxima semana operativa, a atuação de um sistema de baixa pressão no litoral desde Santa Catarina até o sul da Bahia ocasiona chuva fraca a moderada nas bacias dos rios Paraíba do Sul, São Francisco, Tocantins e Xingu. As demais bacias de interesse para o SIN apresentam chuva fraca (Figura 5).

Figura 5 - Precipitação acumulada prevista pelo modelo ECMWF - período de 26/11 a 02/12/2022

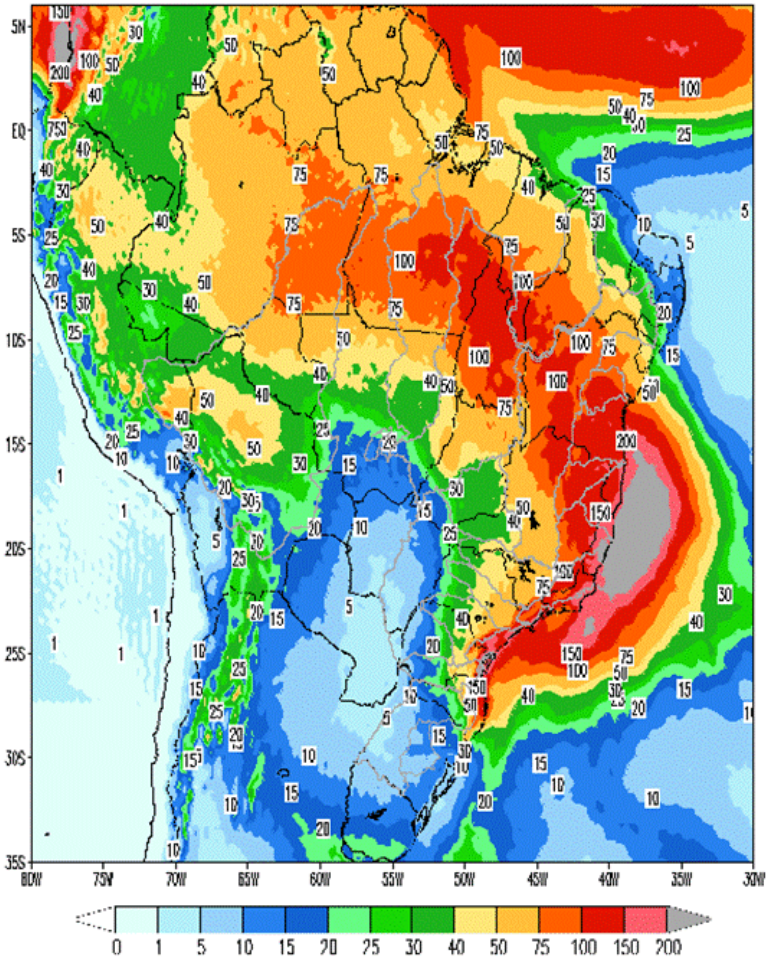

Em comparação com os valores estimados para a semana em curso, prevê-se para a próxima semana operativa ascensão nas afluências dos subsistemas Sudeste/Centro-Oeste, Nordeste e Norte e recessão nas afluências do subsistema Sul. A previsão mensal para dezembro indica a ocorrência de afluências abaixo da média histórica para os subsistemas Sudeste/Centro-Oeste, Sul e Nordeste e acima da média histórica para o subsistema Norte.

Tabela 2 – Previsão de ENAs do PMO de Dezembro/2022

PMO de Dezembro/2022 - ENAs previstas				
Subsistema	26/11 a 02/12/2022		Mês de dezembro	
	MWmed	%MLT	MWmed	%MLT
SE/CO	31.537	87	45.713	95
S	4.457	51	6.035	81
NE	5.605	85	7.990	81
N	7.495	143	13.187	159

O conteúdo desta publicação foi produzido pelo ONS com base em dados e informações de conhecimento público. É de responsabilidade exclusiva dos agentes e demais interessados a obtenção de outros dados e informações, a realização de análises, estudos e avaliações para fins de tomada de decisões, definição de estratégias de atuação, assunção de compromissos e obrigações e quaisquer outras finalidades, em qualquer tempo e sob qualquer condição. É proibida a reprodução ou utilização total ou parcial do presente sem a identificação da fonte.

5. PREVISÃO DE CARGA

A dinâmica da carga de energia é impactada, principalmente, por fatores climáticos e econômicos. Fatores como ocorrência de temperaturas amenas e recuo da confiança dos principais indicadores econômicos, tem se refletido diretamente no comportamento da carga nos últimos meses. O aprofundamento da desaceleração que vem sendo observado na Indústria, com queda do nível de utilização da capacidade instalada, piora da percepção sobre a procura interna e externa por produtos industriais, aumento do nível de estoques e ainda dificuldades na obtenção de insumos por alguns segmentos têm se refletido no consumo de energia desse segmento. É importante destacar que em outubro todos os indicadores disponibilizados pela FGV apresentaram recuo. A confiança dos consumidores, divulgada pela FGV em novembro/22, caiu pelo segundo mês consecutivo. De acordo com a FGV, passado o efeito das transferências de renda, os consumidores de baixa renda voltaram a se sentir menos satisfeitos sobre a situação financeira familiar e revisaram suas expectativas para baixo nos próximos meses. Mesmo com uma queda das perspectivas sobre a inflação e um efeito ainda positivo no mercado de trabalho há um aumento do pessimismo sobre as finanças familiares nos próximos meses.

As previsões de carga para a próxima semana operativa também levaram em consideração as sinalizações meteorológicas para o período, que em termos gerais, indicam condições de estabilidade para todas as regiões do país. A semana em curso registrou temperaturas elevadas durante todo o período nas capitais dos subsistemas Sudeste/Centro-Oeste e Sul, apesar do suave declínio observado nos últimos dias, as temperaturas permanecem altas, porém em patamares ligeiramente inferiores aos observados na semana em curso, com ocorrência de precipitação, inclusive.

As capitais dos subsistemas Nordeste e Norte deverão apresentar temperaturas elevadas, apesar expectativa de ocorrência de precipitação durante todo o período. Cabe destacar que Salvador, segundo as previsões meteorológicas, deverá acumular maiores totais de precipitação em relação às demais capitais nordestinas.

Para o mês de dezembro/22, os valores de carga previstos indicam taxas de crescimento de 1,6% para o subsistema Sudeste/Centro-Oeste e 10,7% para o Norte quando comparadas ao mesmo mês do ano anterior. Para os subsistemas Sul e Nordeste são esperadas variações negativas de 2,8% e 0,5%, respectivamente, em relação a dezembro do ano passado. Cabe destacar que a taxa apresentada no subsistema Norte está associada a retomada de carga de um CL da rede básica que vem se dando de forma gradativa ao longo dos últimos meses.

Tabela 3 – Evolução da carga do PMO de Dezembro 2022

Subsistema	CARGA SEMANAL (MWmed)						CARGA MENSAL (MWmed)	
	1ª Sem	2ª Sem	3ª Sem	4ª Sem	5ª Sem	6ª Sem	dez/22	Var. (%) dez/22 -> dez/21
SE/CO	40.549	40.842	41.309	41.049	40.167	39.680	40.785	1,6%
Sul	12.280	12.402	12.768	12.486	11.537	11.350	12.267	-2,8%
Nordeste	11.572	11.723	11.880	11.613	11.344	11.281	11.624	-0,5%
Norte	6.771	6.769	6.742	6.664	6.460	6.418	6.658	10,7%
SIN	**71.172**	**71.736**	**72.699**	**71.812**	**69.508**	**68.729**	**71.334**	**1,2%**

O conteúdo desta publicação foi produzido pelo ONS com base em dados e informações de conhecimento público. É de responsabilidade exclusiva dos agentes e demais interessados a obtenção de outros dados e informações, a realização de análises, estudos e avaliações para fins de tomada de decisões, definição de estratégias de atuação, assunção de compromissos e obrigações e quaisquer outras finalidades, em qualquer tempo e sob qualquer condição. É proibida a reprodução ou utilização total ou parcial do presente sem a identificação da fonte.

6. PRINCIPAIS RESULTADOS

6.1. CUSTO MARGINAL DE OPERAÇÃO (CMO)

A tabela a seguir apresenta o CMO, por subsistema e patamar de carga para próxima semana operativa.

Tabela 4 – CMO por patamar de carga

Patamares de Carga	CMO (R$/MWh)			
	SE/CO	S	NE	N
Pesada	0,07	0,07	0,07	0,07
Média	0,07	0,07	0,07	0,07
Leve	0,07	0,07	0,07	0,07
Média Semanal	0,07	0,07	0,07	0,07

Na figura a seguir é apresentada a evolução do CMO médio semanal ao longo deste PMO.

Figura 6 – Evolução semanal do CMO

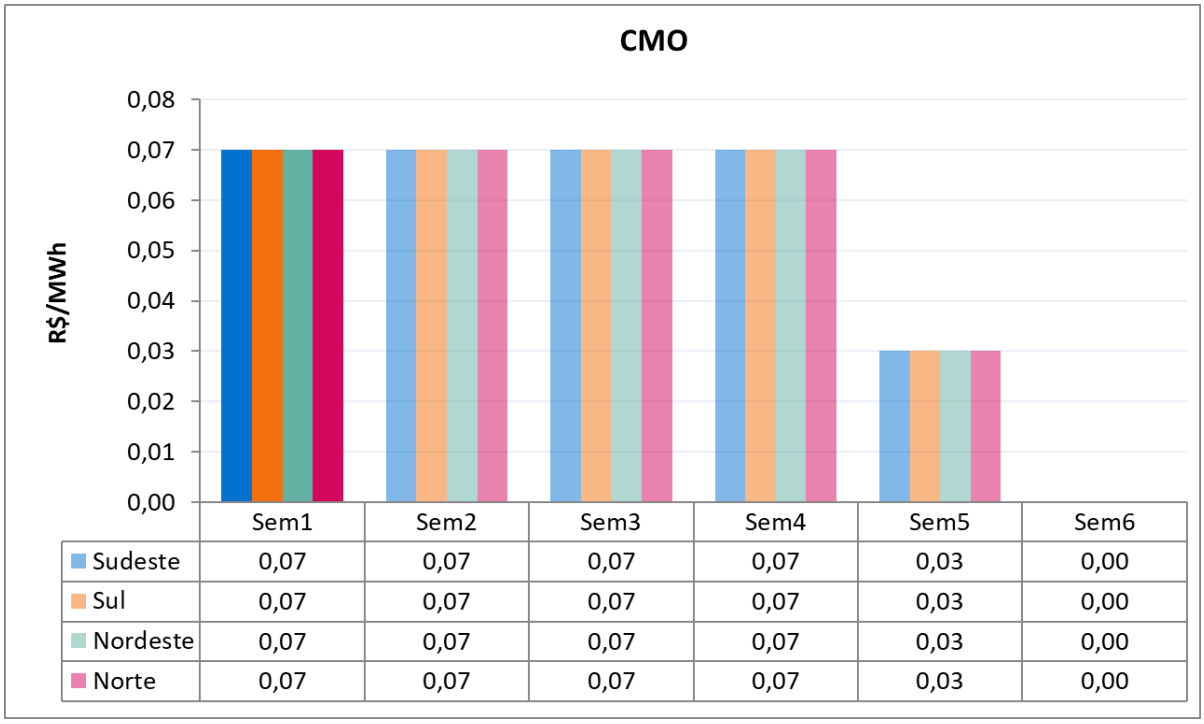

6.2. POLÍTICA DE OPERAÇÃO ENERGÉTICA

Para esta semana operativa, está prevista a seguinte política de intercâmbio de energia entre regiões:

Região SE/CO → Geração para atendimento à carga e fechamento de ponta.

Região Sul → Geração para atendimento à carga e fechamento de ponta.

Região NE → Manutenção da exploração das disponibilidades energéticas, maximização da exportação para SE/CO, respeitando-se as restrições hidráulicas e os limites elétricos vigentes.

Região Norte → Exploração das disponibilidades energéticas e fechamento de ponta.

O conteúdo desta publicação foi produzido pelo ONS com base em dados e informações de conhecimento público. É de responsabilidade exclusiva dos agentes e demais interessados a obtenção de outros dados e informações, a realização de análises, estudos e avaliações para fins de tomada de decisões, definição de estratégias de atuação, assunção de compromissos e obrigações e quaisquer outras finalidades, em qualquer tempo e sob qualquer condição. É proibida a reprodução ou utilização total ou parcial do presente sem a identificação da fonte.

7. GERAÇÃO TÉRMICA

A Figura 7 apresenta, para cada subsistema, o despacho térmico por modalidade indicado pelo Decomp para a próxima semana operativa.

Figura 7 – Geração térmica para a próxima semana operativa

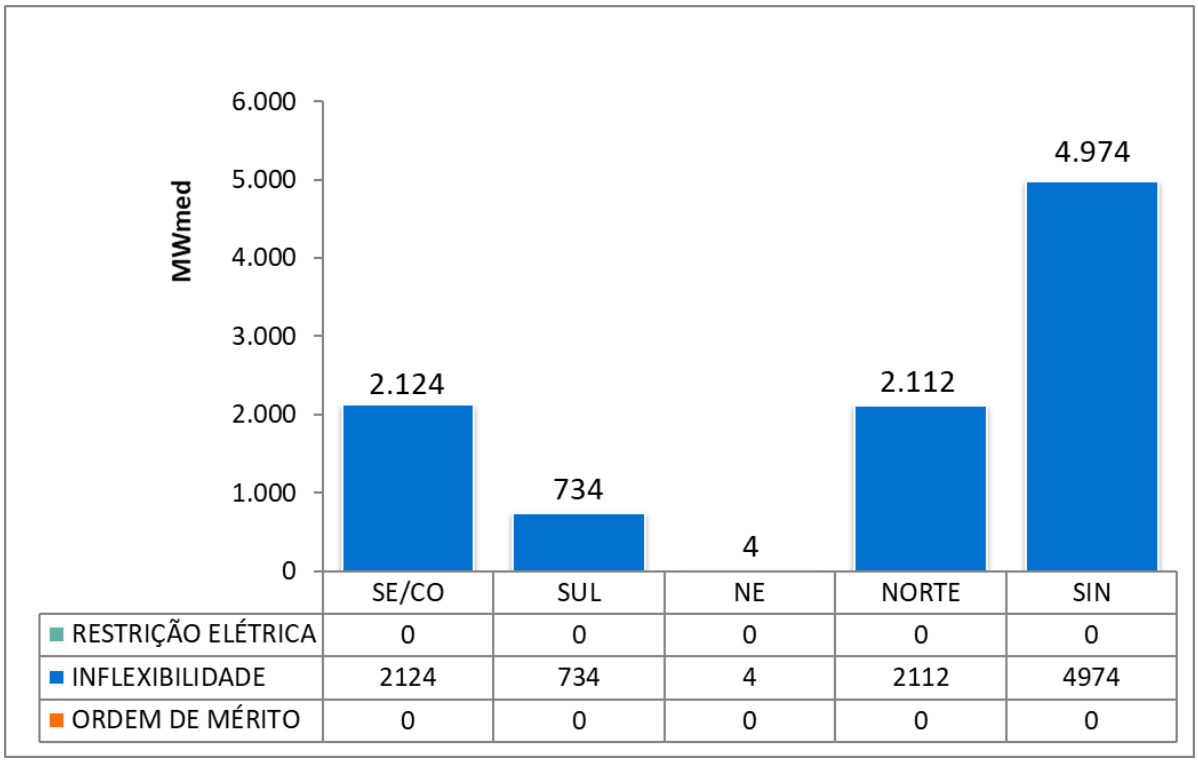

Na tabela abaixo segue a Indicação de despacho antecipado por ordem de mérito de custo para a semana de 28/01/2023 a 03/02/2023.

Tabela 5 – UTEs com contrato de combustível GNL

UTE			Benefício (R$/MWh)		
Nome	Cod	CVU (R$/MWh)	Carga Pesada	Carga Média	Carga Leve
SANTA CRUZ	86	337,26	0,09 (2)	0,09 (2)	0,09 (2)
LUIZORMELO	15	520,60	0,09 (2)	0,09 (2)	0,09 (2)
PSERGIPE I	224	403,83	0,09 (2)	0,09 (2)	0,09 (2)

(1) Comandado o despacho antecipado por ordem de mérito de custo nesse patamar

(2) NÃO foi comandado o despacho antecipado por ordem de mérito de custo nesse patamar

Assim sendo, não há previsão de despacho antecipado por ordem de mérito de custo para as UTE Santa Cruz, Luiz O. R. Melo e Porto Sergipe I, para a semana de 28/01 a 03/02/2023.

A UTE Santa Cruz tem previsão de despacho por inflexibilidade, declarada pelo agente, até 30/12/2022 e de 07/01/2023 até 27/01/2023.

O conteúdo desta publicação foi produzido pelo ONS com base em dados e informações de conhecimento público. É de responsabilidade exclusiva dos agentes e demais interessados a obtenção de outros dados e informações, a realização de análises, estudos e avaliações para fins de tomada de decisões, definição de estratégias de atuação, assunção de compromissos e obrigações e quaisquer outras finalidades, em qualquer tempo e sob qualquer condição. É proibida a reprodução ou utilização total ou parcial do presente sem a identificação da fonte.

8. IMPORTAÇÃO DE ENERGIA

8.1. República Oriental do Uruguai

Para a próxima semana operativa, foram declaradas as seguintes ofertas de importação de energia da República Oriental do Uruguai para o Sistema Interligado Nacional - SIN através da conversora de Melo (500 MW).

- **Enel**

Tabela 6 – Energia ofertada para importação

	Oferta de Energia para a Semana de 26/11 a 02/12 (MWmed)						
	Bloco 1	Bloco 2	Bloco 3	Bloco 4	Bloco 5	Bloco 6	Total
Carga Pesada	50	50	50	50	25	25	250
Carga Média	50	50	50	50	25	25	250
Carga Leve	50	50	50	50	25	25	250
CVU (R$/MWh)	546,98	1.270,97	1.617,63	1.826,94	2.579,13	2.853,84	

- **BTG Pactual**

Tabela 7 – Energia ofertada para importação

	Oferta de Energia para a Semana de 26/11 a 02/12 (MWmed)						
	Bloco 1	Bloco 2	Bloco 3	Bloco 4	Bloco 5	Bloco 6	Total
Carga Pesada	50	50	50	50	25	25	250
Carga Média	50	50	50	50	25	25	250
Carga Leve	50	50	50	50	25	25	250
CVU (R$/MWh)	546,28	1.273,26	1.620,38	1.829,96	2.583,14	2.858,21	

8.2. República da Argentina

Para esta semana operativa, não houve oferta de importação de energia da República da Argentina.

Nota: Detalhes sobre a importação de energia vide Portaria Nº 339, de 15 de agosto de 2018 disponível em: http://pesquisa.in.gov.br/imprensa/jsp/visualiza/index.jsp?data=17/08/2018&jornal=515&pagina=60&totalArquivos=136

O conteúdo desta publicação foi produzido pelo ONS com base em dados e informações de conhecimento público. É de responsabilidade exclusiva dos agentes e demais interessados a obtenção de outros dados e informações, a realização de análises, estudos e avaliações para fins de tomada de decisões, definição de estratégias de atuação, assunção de compromissos e obrigações e quaisquer outras finalidades, em qualquer tempo e sob qualquer condição. É proibida a reprodução ou utilização total ou parcial do presente sem a identificação da fonte.

9. ARMAZENAMENTOS OPERATIVOS

Para uma melhor avaliação de diversos cenários hidrometeorológicos, notadamente, aqueles de curto prazo e suas influências nas previsões de vazões nos subsistemas, os resultados deste PMO contemplam cenários de afluências visando melhor representar a ocorrência de precipitação e, consequentemente, seus efeitos sobre as afluências e armazenamentos.

Além dos resultados associados ao valor esperado das previsões de afluências, as simulações operativas também foram realizadas com os limites superior e inferior das previsões de afluências. Apresentamos a seguir as correspondentes energias naturais afluentes e os resultados obtidos com a aplicação dos diferentes cenários de afluência.

Tabela 8 – Previsão de ENA dos cenários de sensibilidade

Subsistema	ENERGIAS NATURAIS AFLUENTES					
	Previsão Mensal					
	LI		VE		LS	
	(MWmed)	%MLT	(MWmed)	%MLT	(MWmed)	%MLT
SE/CO	33.350	**69**	45.713	**95**	58.195	**121**
Sul	3.402	**46**	6.035	**81**	9.251	**124**
Nordeste	5.516	**56**	7.990	**81**	10.437	**106**
Norte	10.513	**127**	13.187	**159**	15.856	**192**

Tabela 9 – Previsão de %EARmáx para o final do mês

Subsistema	% EARmáx 25/11	% EARmáx - 31/12		
	NÍVEL INICIAL	NÍVEL PMO		
	VE	LI	VE	LS
SE/CO	**46,8**	**44,7**	**52,1**	**54,8**
Sul	**81,9**	**70,8**	**74,0**	**90,5**
Nordeste	**58,6**	**60,6**	**66,0**	**69,8**
Norte	**51,5**	**47,3**	**49,5**	**57,0**

O conteúdo desta publicação foi produzido pelo ONS com base em dados e informações de conhecimento público. É de responsabilidade exclusiva dos agentes e demais interessados a obtenção de outros dados e informações, a realização de análises, estudos e avaliações para fins de tomada de decisões, definição de estratégias de atuação, assunção de compromissos e obrigações e quaisquer outras finalidades, em qualquer tempo e sob qualquer condição. É proibida a reprodução ou utilização total ou parcial do presente sem a identificação da fonte.

10. RESERVATÓRIOS EQUIVALENTES DE ENERGIA

A seguir são apresentadas as previsões de Energia Natural Afluente para a próxima semana operativa e para o mês de dezembro, bem como as previsões de Energia Armazenada nos Reservatórios Equivalentes de Energia – REE, deste PMO.

Tabela 10 – Previsão de ENA por REE

Valor Esperado das Energias Naturais Afluentes				
REE	Previsão Semanal		Previsão Mensal	
	26/11/2022 a 02/12/2022		dez/22	
	(MWmed)	%MLT	(MWmed)	%MLT
Sudeste	7.474	125	8.103	98
Madeira	5.949	150	7.229	132
Teles Pires	1.499	89	3.017	127
Itaipu	3.417	112	4.480	147
Paraná	10.914	57	19.168	73
Paranapanema	1.887	78	3.255	124
Sul	1.519	35	2.212	62
Iguaçu	2.938	66	3.822	98
Nordeste	5.605	85	7.990	81
Norte	4.814	133	6.214	112
Belo Monte	2.298	165	6.414	260
Manaus	445	200	699	269

Tabela 11 – Previsão de %EARmáx por REE

% Energia Armazenável Máxima		
REE	Previsão Semanal	Previsão Mensal
	02-dez	31-dez
	(%EARmáx)	(%EARmáx)
Sudeste	50,7	55,9
Madeira	7,6	54,5
Teles Pires	11,0	42,4
Itaipu	20,7	100,0
Paraná	42,8	48,2
Paranapanema	76,4	80,6
Sul	66,2	60,7
Iguaçu	85,9	87,1
Nordeste	58,9	66,0
Norte	49,5	49,0
Belo Monte	70,3	-
Manaus	56,4	61,1

O conteúdo desta publicação foi produzido pelo ONS com base em dados e informações de conhecimento público. É de responsabilidade exclusiva dos agentes e demais interessados a obtenção de outros dados e informações, a realização de análises, estudos e avaliações para fins de tomada de decisões, definição de estratégias de atuação, assunção de compromissos e obrigações e quaisquer outras finalidades, em qualquer tempo e sob qualquer condição. É proibida a reprodução ou utilização total ou parcial do presente sem a identificação da fonte.

11. DESPACHO TÉRMICO POR MODALIDADE, PATAMAR DE CARGA E USINA

Nas tabelas abaixo, a diferenciação entre geração por inflexibilidade e por ordem de mérito tem caráter informativo, com o objetivo de detalhar a informação de inflexibilidade enviada pelos respectivos agentes para o PMO. Ressalta-se que nas etapas de Programação Diária e Tempo Real, o montante despachado nas usinas termelétricas indicadas por ordem de mérito é plenamente intitulado como ordem de mérito.

REGIÃO SUDESTE/CENTRO-OESTE																	
Térmicas Potência (MW)	Combustível	CVU (R$/MWh)	Inflexibilidade			Ordem de Mérito			Total Mérito e INFL.			Razão Elétrica			Total UTE		
			P	M	L	P	M	L	P	M	L	P	M	L	P	M	L
ATLAN_CSA (255)	Resíduos	0,00	168,7	168,7	168,7				168,7	168,7	168,7				168,7	168,7	168,7
CUIABA CC (529)	Gás	---															
W.ARJONA* (177)	Gás	---															
W.ARJONA O* (177)	Diesel	---															
ANGRA 2 (1350)	Nuclear	20,12	1080,0	939,0	527,0				1080,0	939,0	527,0				1080,0	939,0	527,0
ANGRA 1 (640)	Nuclear	31,17	640,0	640,0	640,0				640,0	640,0	640,0				640,0	640,0	640,0
NORTEFLU 1 (400)	Gás	98,80															
NORTEFLU 2 (100)	Gás	115,04															
O.PINTADA (50)	Biomassa	132,53															
UTE STA VI (41)	Biomassa	143,16															
PREDILECTA (5)	Biomassa	187,30															
NORTEFLU 3 (200)	Gás	219,20															
ATLANTICO (235)	Resíduos	230,62	218,7	218,7	218,7				218,7	218,7	218,7				218,7	218,7	218,7
ST.CRUZ 34 (436)	Óleo	310,41															
T.LAGOAS (350)	Gás	319,34															
BAIXADA FL (530)	Gás	332,76															
SANTA CRUZ (500)	GNL	337,26	146,8	146,8	146,8				146,8	146,8	146,8				146,8	146,8	146,8
TERMORIO (989)	Gás	381,73															
CUBATAO (216)	Gás	400,40															
SEROPEDICA (360)	Gás	469,38															
PIRAT.12 O (200)	Gás	470,34															
LUIZORMELO (204)	GNL	520,60															
JUIZ DE FO (87)	Gás	522,96															
NPIRATINGA (572)	Gás	654,42															
UTE GNA I (1338)	Gás	655,49															
NORTEFLU 4 (127)	Gás	787,45															
T.MACAE (929)	Gás	886,89															
TNORTE 2 (349)	Óleo	910,86															
CAMPOS (25)	Gás	978,10															
VIANA (175)	Óleo	1124,55															
IBIRITE (235)	Gás	1671,95															
DAIA (44)	Diesel	1832,82															
GOIANIA 2 (140)	Diesel	1933,04															
KARKEY 013 (259)	Gás	1945,20	4,0	4,0	4,0				4,0	4,0	4,0				4,0	4,0	4,0
KARKEY 019 (116)	Gás	1945,20	11,0	11,0	11,0				11,0	11,0	11,0				11,0	11,0	11,0
PORSUD II (78)	Gás	2180,26															
PORSUD I (116)	Gás	2197,36															
PALMEIR_GO (176)	Diesel	2250,46															
XAVANTES (54)	Diesel	2639,39															
PAULINIA (16)	Gás	2793,77	15,7	15,7	15,7				15,7	15,7	15,7				15,7	15,7	15,7
LORM_PCS (36)	Gás	2922,81	34,6	34,6	34,6				34,6	34,6	34,6				34,6	34,6	34,6
POVOACAO I (75)	Gás	2922,81	72,0	72,0	72,0				72,0	72,0	72,0				72,0	72,0	72,0
VIANA I (37)	Gás	2922,81	36,0	36,0	36,0				36,0	36,0	36,0				36,0	36,0	36,0
TOTAL SE/CO (12752)			2427,5	2286,5	1874,5	0,0	0,0	0,0	2427,5	2286,5	1874,5	0,0	0,0	0,0	2427,5	2286,5	1874,5

*Conforme Resolução Autorizativa ANEEL nº 10.422/2021, a UTE William Arjona pode operar com óleo diesel, como combustível alternativo.

O conteúdo desta publicação foi produzido pelo ONS com base em dados e informações de conhecimento público. É de responsabilidade exclusiva dos agentes e demais interessados a obtenção de outros dados e informações, a realização de análises, estudos e avaliações para fins de tomada de decisões, definição de estratégias de atuação, assunção de compromissos e obrigações e quaisquer outras finalidades, em qualquer tempo e sob qualquer condição. É proibida a reprodução ou utilização total ou parcial do presente sem a identificação da fonte.

REGIÃO SUL

Térmicas Potência (MW)	Combustível	CVU (R$/MWh)	Inflexibilidade			Ordem de Mérito			Total Mérito e INFL.			Razão Elétrica			Total UTE		
			P	M	L	P	M	L	P	M	L	P	M	L	P	M	L
URUGUAIANA (640)	Gás	---															
PAMPA SUL (345)	Carvão	82,18	345,0	345,0	345,0				345,0	345,0	345,0				345,0	345,0	345,0
SAO SEPE (8)	Biomassa	103,39	8,0	8,0	8,0				8,0	8,0	8,0				8,0	8,0	8,0
CANDIOTA_3 (350)	Carvão	103,75															
J.LACER. C (363)	Carvão	285,18	320,0	320,0	320,0				320,0	320,0	320,0				320,0	320,0	320,0
J.LACER. B (262)	Carvão	331,67															
J.LAC. A2 (132)	Carvão	333,15	55,0	55,0	55,0				55,0	55,0	55,0				55,0	55,0	55,0
MADEIRA (4)	Biomassa	370,99	2,0	2,0	2,0				2,0	2,0	2,0				2,0	2,0	2,0
J.LAC. A1 (100)	Carvão	392,82															
FIGUEIRA (20)	Carvão	475,68															
B.BONITA I (10)	Gás	650,00	3,7	3,7	3,7				3,7	3,7	3,7				3,7	3,7	3,7
CANOAS (249)	Diesel	698,14															
ARAUCARIA (484)	Gás	2157,20															
TOTAL SUL (2967)			733,7	733,7	733,7	0,0	0,0	0,0	733,7	733,7	733,7	0,0	0,0	0,0	733,7	733,7	733,7

REGIÃO NORDESTE

Térmicas Potência (MW)	Combustível	CVU (R$/MWh)	Inflexibilidade			Ordem de Mérito			Total Mérito e INFL.			Razão Elétrica			Total UTE		
			P	M	L	P	M	L	P	M	L	P	M	L	P	M	L
ERB CANDEI (17)	Biomassa	103,47	4,5	4,5	4,5				4,5	4,5	4,5				4,5	4,5	4,5
PROSPERIDA (28)	Gás	195,14															
TERMOPE (533)	Gás	236,93															
FORTALEZA (327)	Gás	277,36															
T.BAHIA (186)	Gás	374,87															
PSERGIPE I (1593)	GNL	403,83															
VALE ACU (368)	Gás	450,86															
TERMOCEARA (223)	Gás	481,56															
SYKUE I (30)	Biomassa	510,12															
P.PECEM2 (365)	Carvão	776,54															
P.PECEM1 (720)	Carvão	795,30															
PERNAMBU_3 (201)	Óleo	970,28															
MARACANAU (168)	Óleo	1094,26															
TERMOCABO (50)	Óleo	1110,74															
TERMONE (171)	Óleo	1114,58															
TERMOPB (171)	Óleo	1114,58															
CAMPINA_GR (169)	Óleo	1124,57															
SUAPE II (381)	Óleo	1150,85															
CURUMIM (31)	Óleo	1258,47															
GLOBAL I (149)	Óleo	1274,03															
GLOBAL II (149)	Óleo	1274,03															
APOENA (147)	Óleo	1849,76															
GUARANI (150)	Óleo	1849,76															
PETROLINA (136)	Óleo	2029,44															
POTIGUAR_3 (66)	Diesel	3020,76															
POTIGUAR (53)	Diesel	3020,80															
PAU FERRO (94)	Diesel	3372,53															
TERMOMANAU (143)	Diesel	3372,53															
TOTAL NE (6819)			4,5	4,5	4,5	0,0	0,0	0,0	4,5	4,5	4,5	0,0	0,0	0,0	4,5	4,5	4,5

O conteúdo desta publicação foi produzido pelo ONS com base em dados e informações de conhecimento público. É de responsabilidade exclusiva dos agentes e demais interessados a obtenção de outros dados e informações, a realização de análises, estudos e avaliações para fins de tomada de decisões, definição de estratégias de atuação, assunção de compromissos e obrigações e quaisquer outras finalidades, em qualquer tempo e sob qualquer condição. É proibida a reprodução ou utilização total ou parcial do presente sem a identificação da fonte.

REGIÃO NORTE																	
Térmicas Potência (MW)	Combustível	CVU (R$/MWh)	Inflexibilidade			Ordem de Mérito			Total Mérito e INFL.			Razão Elétrica			Total UTE		
			P	M	L	P	M	L	P	M	L	P	M	L	P	M	L
C. ROCHA (85)	Gás	0,00	65,0	65,0	65,0				65,0	65,0	65,0				65,0	65,0	65,0
JARAQUI (75)	Gás	0,00	63,0	63,0	63,0				63,0	63,0	63,0				63,0	63,0	63,0
MANAUARA (67)	Gás	0,00	64,0	64,0	64,0				64,0	64,0	64,0				64,0	64,0	64,0
PONTA NEGR (73)	Gás	0,00	64,0	64,0	64,0				64,0	64,0	64,0				64,0	64,0	64,0
TAMBAQUI (93)	Gás	0,00	63,0	63,0	56,6				63,0	63,0	56,6				63,0	63,0	56,6
MARANHAO3 (519)	Gás	101,00	294,0	326,7	395,8				294,0	326,7	395,8				294,0	326,7	395,8
PARNAIB_IV (56)	Gás	151,69	20,0	20,0	20,0				20,0	20,0	20,0				20,0	20,0	20,0
APARECIDA (166)	Gás	152,14	75,0	75,0	75,0				75,0	75,0	75,0				75,0	75,0	75,0
UTE MAUA 3 (591)	Gás	152,14	264,0	264,0	264,0				264,0	264,0	264,0				264,0	264,0	264,0
PARNAIBA_V (386)	Vapor	204,26	365,0	365,0	365,0				365,0	365,0	365,0				365,0	365,0	365,0
N.VEN2_L22 (27)	Gás	273,69	12,0	12,0	12,0				12,0	12,0	12,0				12,0	12,0	12,0
N.VEN2_L7 (151)	Gás	273,69	45,0	45,0	45,0				45,0	45,0	45,0				45,0	45,0	45,0
N.VENECIA2 (270)	Gás	273,69															
MARAN_VL_7 (336)	Gás	309,20	323,0	333,0	333,0				323,0	333,0	333,0				323,0	333,0	333,0
MARANHAO V (338)	Gás	309,20															
MARANHAOIV (338)	Gás	309,20															
MARANIVL_7 (336)	Gás	309,20	323,0	333,0	333,0				323,0	333,0	333,0				323,0	333,0	333,0
MARAN_VL22 (1)	Gás	309,21	1,0	1,0	1,0				1,0	1,0	1,0				1,0	1,0	1,0
MARANIVL22 (1)	Gás	309,21	1,0	1,0	1,0				1,0	1,0	1,0				1,0	1,0	1,0
P. ITAQUI (360)	Carvão	766,96															
GERAMAR1 (166)	Óleo	1124,53															
GERAMAR2 (166)	Óleo	1124,53															
TOTAL NORTE (4603)			2042,0	2094,7	2157,4	0,0	0,0	0,0	2042,0	2094,7	2157,4	0,0	0,0	0,0	2042,0	2094,7	2157,4

O conteúdo desta publicação foi produzido pelo ONS com base em dados e informações de conhecimento público. É de responsabilidade exclusiva dos agentes e demais interessados a obtenção de outros dados e informações, a realização de análises, estudos e avaliações para fins de tomada de decisões, definição de estratégias de atuação, assunção de compromissos e obrigações e quaisquer outras finalidades, em qualquer tempo e sob qualquer condição. É proibida a reprodução ou utilização total ou parcial do presente sem a identificação da fonte.