1. APRESENTAÇÃO

No mês de julho, todas as bacias de interesse do SIN apresentaram totais de precipitação inferiores à média histórica. Na semana de 23/07 a 29/07/2022 as bacias dos rios Jacuí, Uruguai e Iguaçu apresentaram chuvisco/chuva fraca.

Na semana de 30/07 a 05/08 deve ocorrer chuva fraca nas bacias dos rios Jacuí, Uruguai, Iguaçu, Paranapanema, Tietê, Grande, Paranaíba e no São Francisco.

Para a semana operativa de 30/07 a 05/08/2022, houve oferta de energia da República Oriental do Uruguai. De acordo com o Art. 2º da Portaria MME nº 339, de 15 de agosto de 2018, as ofertas para importação de energia não foram consideradas na elaboração do PMO. Para a referida semana, não houve oferta de energia da República da Argentina.

Os valores médios semanais do Custo Marginal de Operação – CMO dos subsistemas do SIN sofreram as seguintes alterações em relação à semana anterior:

- SE/CO: de R$ 72,01/MWh para R$ 98,67/MWh
- Sul: de R$ 72,01/MWh para R$ 98,67/MWh
- Nordeste: de R$ 72,01/MWh para R$ 98,67/MWh
- Norte: de R$ 72,01/MWh para R$ 98,67/MWh

Desde o dia 01/01/2020, o despacho por ordem de mérito é indicado diariamente pelos resultados do modelo DESSEM. Assim, o despacho por ordem de mérito semanal, conforme publicado nesse documento, tem caráter apenas informativo. Da mesma forma, desde o dia 01/01/2021, a formação de preço deixou o formato semanal/patamar de carga e passou a ser horário, de acordo também com os resultados do modelo DESSEM.

2. NOTÍCIAS

Nos dias 25 e 26 de agosto será realizada a reunião de elaboração do PMO Setembro de 2022, com transmissão ao vivo através do site do ONS.

3. INFORMAÇÕES PARA ESTUDOS ENERGÉTICOS DE MÉDIO PRAZO - CONSTRUÇÃO DA FUNÇÃO DE CUSTO FUTURO

A atualização de dados para os estudos energéticos de médio prazo é realizada mensalmente quando da elaboração do PMO, tendo por base as informações fornecidas pela ANEEL, MME, EPE, CCEE e Agentes, além de diversas áreas do ONS.

O conteúdo desta publicação foi produzido pelo ONS com base em dados e informações de conhecimento público. É de responsabilidade exclusiva dos agentes e demais interessados a obtenção de outros dados e informações, a realização de análises, estudos e avaliações para fins de tomada de decisões, definição de estratégias de atuação, assunção de compromissos e obrigações e quaisquer outras finalidades, em qualquer tempo e sob qualquer condição. É proibida a reprodução ou utilização total ou parcial do presente sem a identificação da fonte.

3.1. ATUALIZAÇÃO DAS INFORMAÇÕES ESTRUTURAIS

3.1.1. Oferta

Nas **Figura 1**, **Figura 2** e **Figura 3**, a seguir, são apresentadas as evoluções da oferta hidroelétrica, termoelétrica e da disponibilidade das usinas não simuladas individualmente, respectivamente, em comparação ao PMO de julho/2022, identificando eventuais atrasos ou antecipações de cronograma feitos na reunião de acompanhamento do Departamento de Monitoramento do Setor Elétrico – DMSE/MME, realizada em 21/07/2022.

Figura 1 - Evolução da potência instalada das UHEs

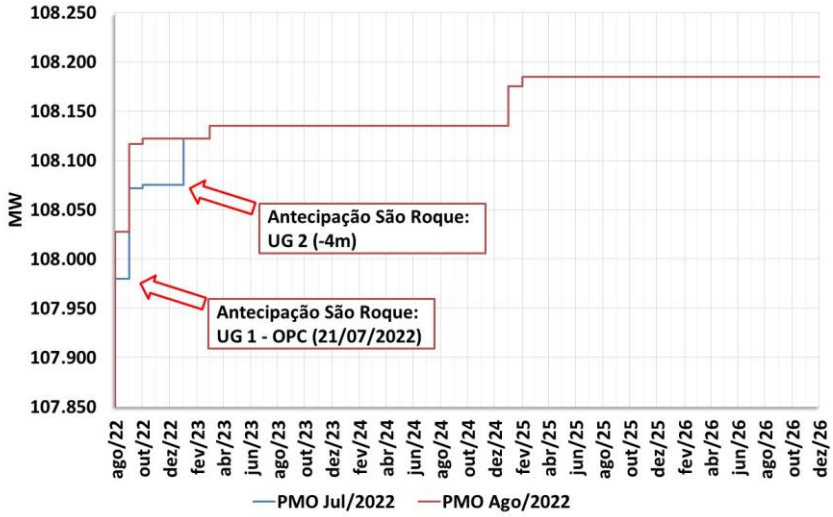

Figura 2 - Evolução da potência instalada das UTEs

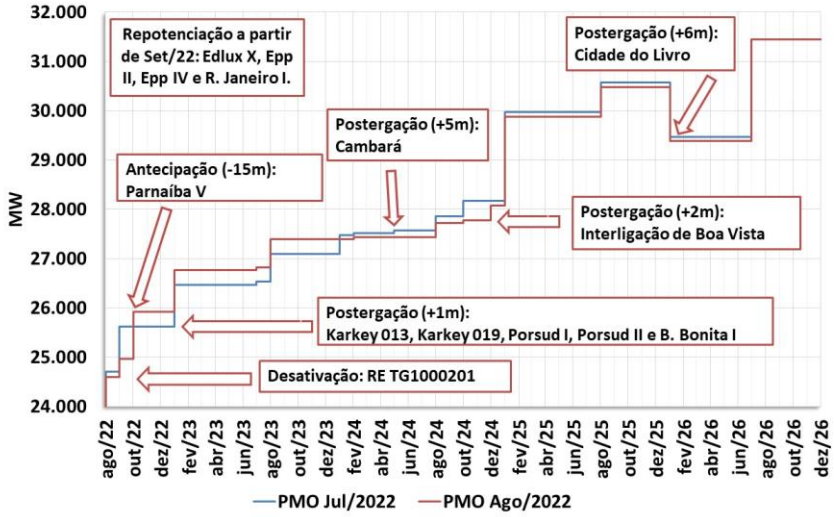

O conteúdo desta publicação foi produzido pelo ONS com base em dados e informações de conhecimento público. É de responsabilidade exclusiva dos agentes e demais interessados a obtenção de outros dados e informações, a realização de análises, estudos e avaliações para fins de tomada de decisões, definição de estratégias de atuação, assunção de compromissos e obrigações e quaisquer outras finalidades, em qualquer tempo e sob qualquer condição. É proibida a reprodução ou utilização total ou parcial do presente sem a identificação da fonte.

Figura 3 - Evolução da disponibilidade das usinas não simuladas

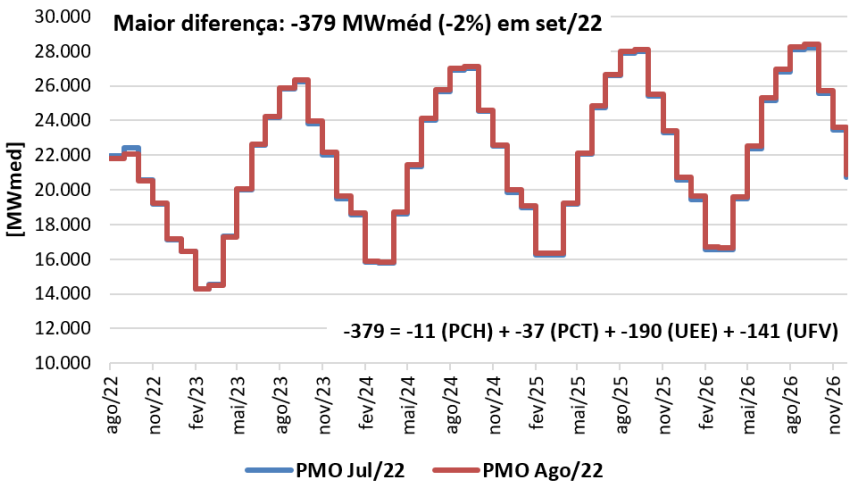

3.1.2. Armazenamentos Iniciais

Na **Figura 4,** a seguir, são apresentados os armazenamentos iniciais equivalentes por subsistema, considerados nos modelos de otimização para a elaboração do PMO de ago/2022, comparados com os do PMO de jul/2022.

Figura 4 – Energia armazenada inicial em jul/22 e ago/22

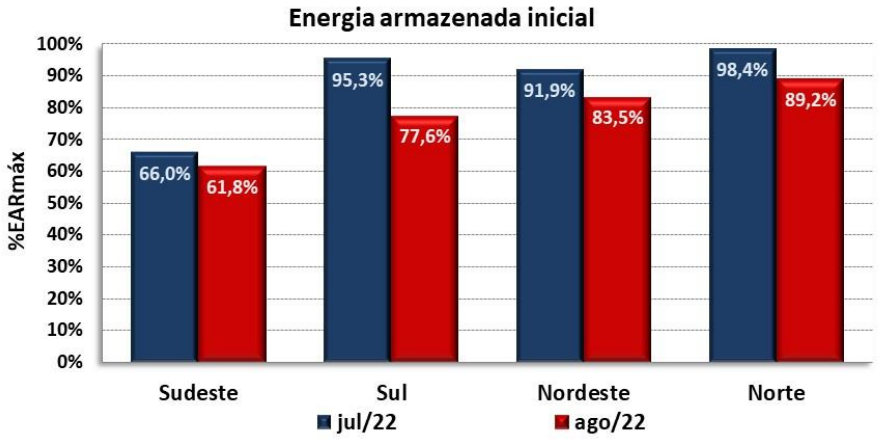

3.1.3. Tendência Hidrológica

Na **tabela 1**, a seguir, são apresentadas as tendências hidrológicas consideradas pelo modelo NEWAVE para o PMO de Agosto/2022, comparadas com o PMO de julho/2022.

O conteúdo desta publicação foi produzido pelo ONS com base em dados e informações de conhecimento público. É de responsabilidade exclusiva dos agentes e demais interessados a obtenção de outros dados e informações, a realização de análises, estudos e avaliações para fins de tomada de decisões, definição de estratégias de atuação, assunção de compromissos e obrigações e quaisquer outras finalidades, em qualquer tempo e sob qualquer condição. É proibida a reprodução ou utilização total ou parcial do presente sem a identificação da fonte.

Tabela 1 – Tendência hidrológica para o PMO de Agosto/2022 – NEWAVE [%MLT]

	PMO julho/2022				PMO agosto/2022			
MÊS	SE/CO	S	NE	N	SE/CO	S	NE	N
jan/22	109	38	142	219				
fev/22	109	33	155	131	108	33	155	132
mar/22	77	98	122	120	76	98	122	120
abr/22	75	156	63	107	74	156	63	107
mai/22	68	222	52	82	68	222	52	82
jun/22	76	233	64	83	75	235	64	81
jul/22					65	75	69	86

* ≥100% MLT < 100% MLT

3.2. DEMAIS ATUALIZAÇÕES

Adicionalmente, neste PMO ocorreram os seguintes destaques:

- Horizonte de estudo: agosto de 2022 a dezembro de 2026;
- Alteração da versão do modelo NEWAVE 28 para versão 28.0.3, que se enquadra no Art. 22, § 1º, II, da Resolução Normativa nº 843/19 sobre correção de erro no código fonte;
- Cronograma de Obras – Reunião DMSE-G de 21/07/2022, com destaque para:

  1. alteração na potência instalada das UTEs EDLUX X, EPP II, EPP IV e R. JANEIRO I do 1º PCS;
  2. postergação na data de tendência das UTEs Karkey 13, Karkey 19, Porsud I e Porsud II do 1º PCS e liberação da operação comercial das UTEs Linhares, Paulínia Verde e Viana I do 1º PCS. A UTE RE TG 1000201 é a única do 1º PCS "sem previsão" e foi retirada da configuração;
  3. antecipação da data de tendência da UTE Parnaíba V, devido à entrada de operação em teste;
  4. operação comercial da UG1 e antecipação da data de tendência da UG2 da UHE São Roque.

- Alteração na potência instalada da UTE Ibirité, conforme Despacho SRG/ANEEL nº 1.755/2022;
- Suspensão da operação comercial da UTE Predilecta, conforme Despacho SRG/ANEEL nº 1.940/2022;
- CVUs de UTEs vendedoras em leilão;
- CVU das UTEs Fortaleza, NorteFluminense 1, 2, 3, 4 e Termopernambuco, conforme Despachos SRG/ANEEL nº 1.796/2022, 1.869/2022 e 1.875/2022;
- CVU da UTE Willian Arjona, com inclusão de custos fixos, conforme Despacho SRG/ANEEL nº 1.865/2022;
- Modelagem da UTE Termomacaé a partir de jul/2026, conforme Despacho ANEEL nº 1.570/2022, que habilita o empreendimento como vencedor no 1º LRC;
- Modelagem na UTE Cuiabá das obrigações assumidas no âmbito do PCS 1/2021 pelas UTEs Edlux X, EPP II, EPP IV e Rio de Janeiro I, conforme Despacho ANEEL nº 1.872/2022;
- Postergação da interligação de Boa Vista ao SIN - " LT Eng Lechuga / Equador / Boa Vista e SE Equador e Boa Vista", para dezembro/2024 e alteração na modelagem da Carga de Boa Vista explicitada via arquivo de cargas adicionais: CADIC.DAT;

O conteúdo desta publicação foi produzido pelo ONS com base em dados e informações de conhecimento público. É de responsabilidade exclusiva dos agentes e demais interessados a obtenção de outros dados e informações, a realização de análises, estudos e avaliações para fins de tomada de decisões, definição de estratégias de atuação, assunção de compromissos e obrigações e quaisquer outras finalidades, em qualquer tempo e sob qualquer condição. É proibida a reprodução ou utilização total ou parcial do presente sem a identificação da fonte.

- Limites de Intercâmbio com valores segundo Relatório Mensal de Limites de Intercâmbio RT-ONS DPL 0365/2022;
- Alterações de restrições operativas para as UHEs Porto Primavera e Jupiá de acordo com os FSAR-H enviados pelos Agentes responsáveis;
- Restrições de defluências das usinas do Rio São Francisco conforme "Informe Sobre o Planejamento e a Programação da Operação dos Aproveitamentos Hidroelétricos da Bacia do Rio São Francisco no PMO de Agosto de 2022";
- Restrições de defluência da UHE Serra da Mesa conforme "Informe Sobre o Planejamento e a Programação da Operação da Bacia do Rio Tocantins no PMO de Agosto de 2022";
- Compatibilização da disponibilidade térmica para os dois primeiros meses de acordo com informação da programação mensal;
- Compatibilização dos valores dos 2 primeiros meses da geração hidráulica mínima das UHEs Itaipu e Tucuruí de acordo com os utilizados na programação mensal;
- Previsões de carga consolidadas para os 2 primeiros meses.

O conteúdo desta publicação foi produzido pelo ONS com base em dados e informações de conhecimento público. É de responsabilidade exclusiva dos agentes e demais interessados a obtenção de outros dados e informações, a realização de análises, estudos e avaliações para fins de tomada de decisões, definição de estratégias de atuação, assunção de compromissos e obrigações e quaisquer outras finalidades, em qualquer tempo e sob qualquer condição. É proibida a reprodução ou utilização total ou parcial do presente sem a identificação da fonte.

4. ANÁLISE DAS CONDIÇÕES HIDROMETEOROLÓGICAS

O avanço de uma nova frente fria pelas regiões Sul e Sudeste no final da próxima semana ocasiona chuvisco/chuva fraca nas bacias dos rios Jacuí, Uruguai e em pontos isolados do Iguaçu (Figura 5).

Figura 5 - Precipitação acumulada prevista pelo modelo ECMWF - período de 30/07 a 05/08/2022

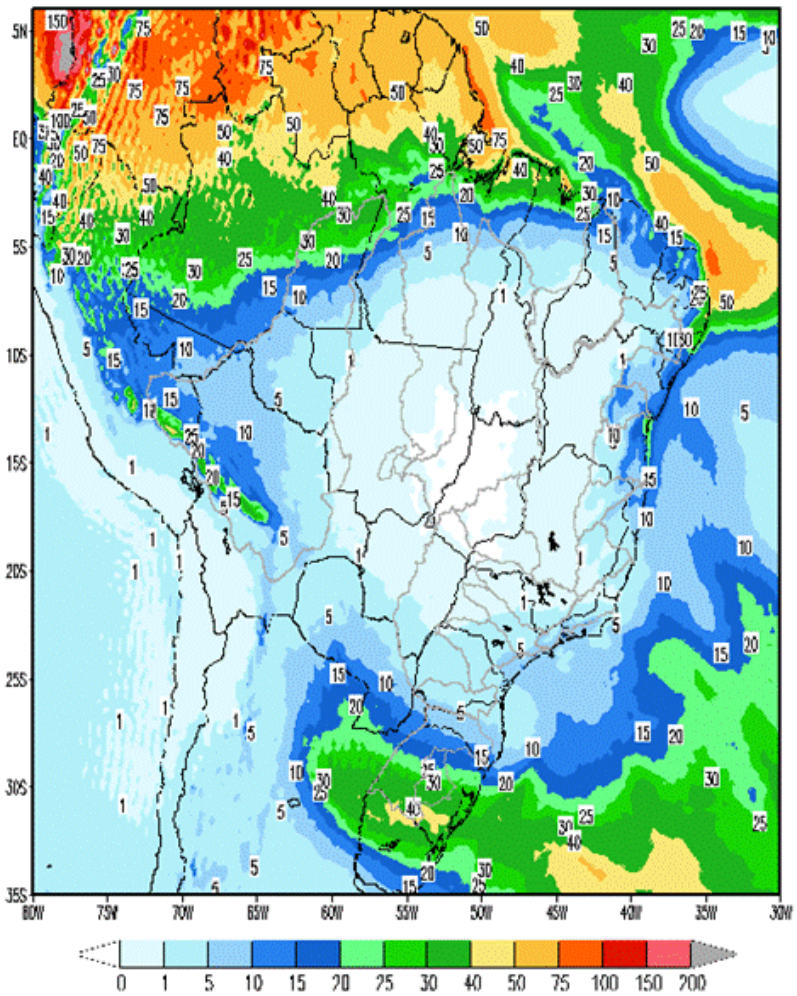

Em comparação com os valores estimados para a semana em curso, prevê-se para a próxima semana operativa recessão nas afluências de todos os subsistemas. A previsão mensal para agosto indica a ocorrência de afluências abaixo da média histórica para todos os subsistemas.

Tabela 2 – Previsão de ENAs do PMO de Agosto/2022

PMO de Agosto/2022 - ENAs previstas				
Subsistema	30/07 a 05/08/2022		Mês de agosto	
	MWmed	%MLT	MWmed	%MLT
SE/CO	14.572	66	13.764	67
S	5.282	52	7.919	80
NE	2.333	68	2.225	67
N	3.536	94	2.845	89

O conteúdo desta publicação foi produzido pelo ONS com base em dados e informações de conhecimento público. É de responsabilidade exclusiva dos agentes e demais interessados a obtenção de outros dados e informações, a realização de análises, estudos e avaliações para fins de tomada de decisões, definição de estratégias de atuação, assunção de compromissos e obrigações e quaisquer outras finalidades, em qualquer tempo e sob qualquer condição. É proibida a reprodução ou utilização total ou parcial do presente sem a identificação da fonte.

5. PREVISÃO DE CARGA

Após acumular três altas consecutivas, o resultado de julho/22 do ICI - Índice de Confiança da Indústria indica uma queda de 1,7 pontos. De acordo com a FGV – Fundação Getúlio Vargas, esse resultado foi influenciado pela moderação do otimismo empresarial quanto à evolução dos negócios ao longo do segundo semestre motivado pelas expectativas menos favoráveis que parecem decorrer da perspectiva de manutenção de níveis elevados de inflação e de juros até o final do ano, além do aumento da incerteza política durante o período eleitoral FGV.

A boa notícia veio do setor Serviços, que depois de dar sinais de desaceleração ao final do primeiro semestre, voltou a subir em julho de forma disseminada entre os segmentos. O resultado favorável foi influenciado tanto pela percepção de melhora da demanda corrente quanto das expectativas para os próximos meses. Segundo a FGV, apesar do período eleitoral aumentar os níveis de incerteza econômica, as medidas de estímulo adotadas pelo governo recentemente devem manter a atividade do setor aquecida e resultar em um terceiro trimestre mais positivo do que inicialmente esperado. Esses fatores têm impactado o comportamento da carga nos últimos meses e foram levados em consideração para as previsões de carga do horizonte do PMO vigente.

As sinalizações meteorológicas indicam para a próxima semana operativa, baixos totais de precipitação e ocorrência de temperaturas mais amenas em parte dos dias, nas capitais dos subsistemas Sudeste/Centro-Oeste e Sul, em relação às temperaturas observadas na semana atual. Cabe ressaltar que as temperaturas observadas nessas regiões durante as últimas semanas têm se apresentado em níveis mais elevados que o comportamento típico da estação do inverno.

Nos subsistemas Nordeste e Norte, as temperaturas previstas indicam condições de estabilidade quando comparadas às últimas semanas e ao comportamento típico para essa época do ano, ou seja, as máximas previstas se apresentarão elevadas acompanhadas por pancadas de chuva no final da tarde e à noite.

Para o mês de agosto/22 são esperadas taxas de crescimento de 0,5% para o subsistema Sudeste/Centro-Oeste e 5,2% para o subsistema Norte. Para o subsistema NE é esperada uma variação negativa de 1,1%, enquanto para o subsistema Sul, o valor mensal previsto indica uma variação nula em comparação ao mesmo mês do ano anterior. A taxa de crescimento do Subsistema Norte está associada, em parte, à retomada de carga de dois CL's da rede básica após reduções ocorridas anteriormente.

Tabela 3 – Evolução da carga do PMO de Agosto 2022

Subsistema	CARGA SEMANAL (MWmed)					CARGA MENSAL (MWmed)	
	1ª Sem	2ª Sem	3ª Sem	4ª Sem	5ª Sem	ago/22	Var. (%) ago/22 -> ago/21
SE/CO	38.424	38.560	38.829	38.955	39.002	38.759	0,5%
Sul	11.596	11.670	11.686	11.672	11.642	11.657	0,0%
Nordeste	10.848	10.958	11.027	11.074	11.118	11.008	-1,1%
Norte	6.457	6.558	6.678	6.679	6.674	6.615	5,2%
SIN	67.325	67.746	68.220	68.380	68.436	68.039	0,6%

O conteúdo desta publicação foi produzido pelo ONS com base em dados e informações de conhecimento público. É de responsabilidade exclusiva dos agentes e demais interessados a obtenção de outros dados e informações, a realização de análises, estudos e avaliações para fins de tomada de decisões, definição de estratégias de atuação, assunção de compromissos e obrigações e quaisquer outras finalidades, em qualquer tempo e sob qualquer condição. É proibida a reprodução ou utilização total ou parcial do presente sem a identificação da fonte.

6. PRINCIPAIS RESULTADOS

6.1. CUSTO MARGINAL DE OPERAÇÃO (CMO)

A tabela a seguir apresenta o CMO, por subsistema e patamar de carga para próxima semana operativa.

Tabela 4 – CMO por patamar de carga

Patamares de Carga	CMO (R$/MWh)			
	SE/CO	S	NE	N
Pesada	99,58	99,58	99,58	99,58
Média	99,23	99,23	99,23	99,23
Leve	97,69	97,69	97,69	97,69
Média Semanal	98,67	98,67	98,67	98,67

Na figura a seguir é apresentada a evolução do CMO médio semanal ao longo deste PMO.

Figura 6 – Evolução semanal do CMO

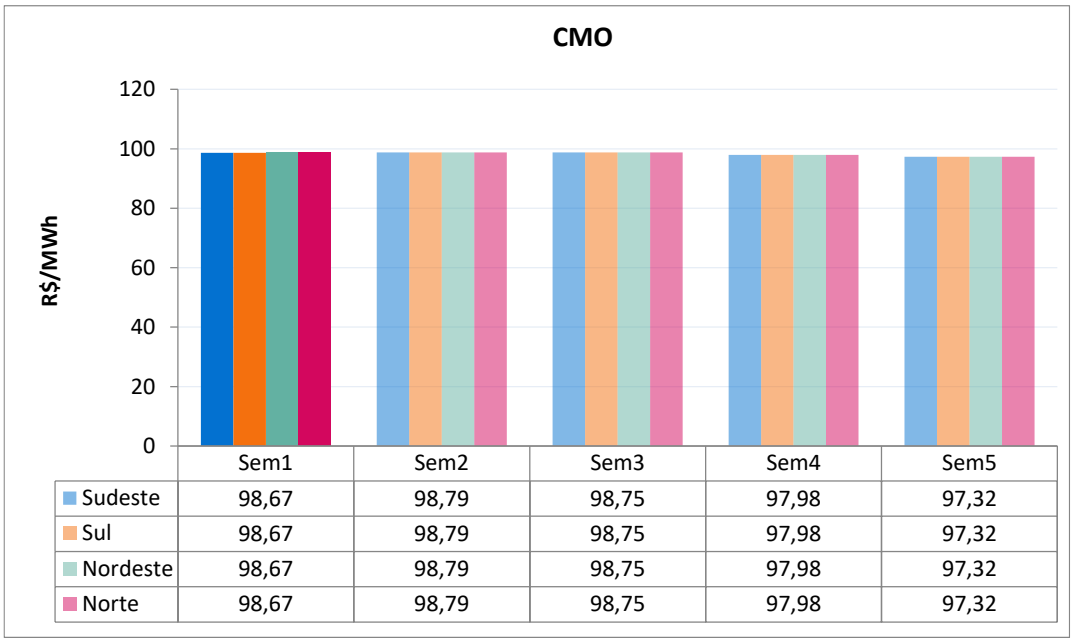

6.2. POLÍTICA DE OPERAÇÃO ENERGÉTICA

Para esta semana operativa, está prevista a seguinte política de intercâmbio de energia entre regiões:

Região SE/CO → Geração hidráulica visando a preservação dos armazenamentos, controle defluências no baixo Paraná e controle de cota em Itaipu.

Região Sul → Geração dimensionada em função das condições de atendimento à carga do SIN prioritariamente na ponta do sistema.

Região NE → Manutenção da exploração das disponibilidades energéticas, maximização da exportação para SE/CO, respeitando-se as restrições hidráulicas e os limites elétricos vigentes.

Região Norte → Exploração das disponibilidades energéticas, fechamento de ponta.

O conteúdo desta publicação foi produzido pelo ONS com base em dados e informações de conhecimento público. É de responsabilidade exclusiva dos agentes e demais interessados a obtenção de outros dados e informações, a realização de análises, estudos e avaliações para fins de tomada de decisões, definição de estratégias de atuação, assunção de compromissos e obrigações e quaisquer outras finalidades, em qualquer tempo e sob qualquer condição. É proibida a reprodução ou utilização total ou parcial do presente sem a identificação da fonte.

7. ANÁLISE DA VARIAÇÃO SEMANAL DO CMO

Esta análise visa identificar os principais parâmetros cujas atualizações impactaram os CMO deste PMO, em comparação com os valores obtidos na última revisão.

Foram realizados 8 estudos, onde o caso inicial foi construído com base nos dados preliminares deste PMO, sendo utilizada a Função de Custo Futuro elaborada no PMO do mês anterior. Para o primeiro estudo foram retiradas as restrições de limites conjunturais e a partida dos reservatórios foi estimada conforme indicado para esta semana operativa na última revisão do PMO do mês anterior. O segundo estudo foi realizado com os dados do caso inicial, tendo substituída a previsão de vazões e, em seguida, a Função de Custo Futuro do PMO do mês anterior pela nova Função elaborada para este PMO. A junção destes dois estudos é denominada de "acoplamento".

A partir do conjunto de dados do segundo estudo foram elaborados os demais casos, onde foram atualizados, sequencialmente, as seguintes informações: partida dos reservatórios, previsão de carga, disponibilidade das usinas térmicas e hidráulicas, restrições de limites elétricos, restrições hidráulicas e, por fim, os demais dados que compõem toda informação referente a atual revisão.

Os custos marginais de operação dos quatro subsistemas que compõem o SIN permanecem acoplados nesta semana operativa. A Figura 7 apresenta a análise de variação dos CMO dos subsistemas Sudeste/Centro-Oeste, Sul, Nordeste e Norte e, conforme pode ser observado, o principal fator que contribuiu para elevação do CMO foi a atualização da previsão de vazões em conjunto com a Função de Custo Futuro.

Figura 7– Análise da variação do CMO nos subsistemas do SIN

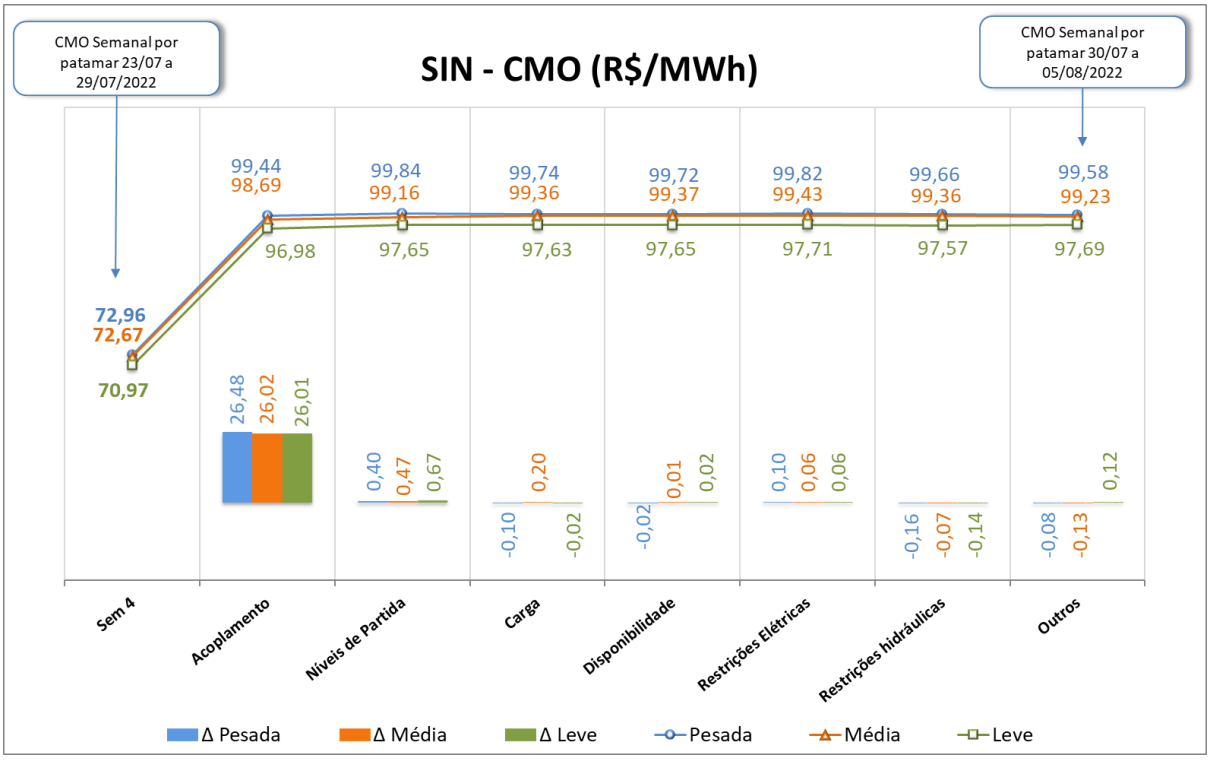

O conteúdo desta publicação foi produzido pelo ONS com base em dados e informações de conhecimento público. É de responsabilidade exclusiva dos agentes e demais interessados a obtenção de outros dados e informações, a realização de análises, estudos e avaliações para fins de tomada de decisões, definição de estratégias de atuação, assunção de compromissos e obrigações e quaisquer outras finalidades, em qualquer tempo e sob qualquer condição. É proibida a reprodução ou utilização total ou parcial do presente sem a identificação da fonte.

8. GERAÇÃO TÉRMICA

A Figura 8 apresenta, para cada subsistema, o despacho térmico por modalidade indicado pelo Decomp para a próxima semana operativa.

Figura 8 – Geração térmica para a próxima semana operativa

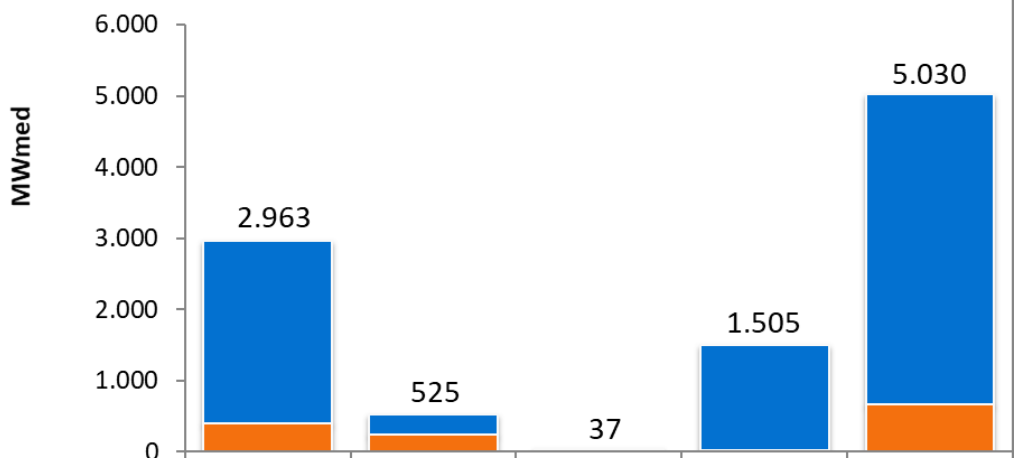

	SE/CO	SUL	NE	NORTE	SIN
RESTRIÇÃO ELÉTRICA	0	0	0	0	0
INFLEXIBILIDADE	2563	279	31	1488	4361
ORDEM DE MÉRITO	400	246	6	17	669

Na tabela abaixo segue a Indicação de despacho antecipado por ordem de mérito de custo para a semana de 01/10/2022 a 07/10/2022.

Tabela 5 – UTEs com contrato de combustível GNL

UTE			Benefício (R$/MWh)		
Nome	Cod	CVU (R$/MWh)	Carga Pesada	Carga Média	Carga Leve
SANTA CRUZ	86	405,93	93,32 (2)	93,32 (2)	93,21 (2)
LUIZORMELO	15	631,14	93,32 (2)	93,32 (2)	93,21 (2)
PSERGIPE I	224	500,85	93,32 (2)	93,32 (2)	93,20 (2)

(1) Comandado o despacho antecipado por ordem de mérito de custo nesse patamar

(2) NÃO foi comandado o despacho antecipado por ordem de mérito de custo nesse patamar

Assim sendo, não há previsão de despacho antecipado por ordem de mérito de custo para as UTE Santa Cruz, Luiz O. R. Melo e Porto Sergipe I, para a semana de 01/10 a 07/10/2022.

A UTE Santa Cruz tem previsão de despacho, por inflexibilidade declarada pelo agente para o período de 13/08/2022 a 25/11/2022.

O conteúdo desta publicação foi produzido pelo ONS com base em dados e informações de conhecimento público. É de responsabilidade exclusiva dos agentes e demais interessados a obtenção de outros dados e informações, a realização de análises, estudos e avaliações para fins de tomada de decisões, definição de estratégias de atuação, assunção de compromissos e obrigações e quaisquer outras finalidades, em qualquer tempo e sob qualquer condição. É proibida a reprodução ou utilização total ou parcial do presente sem a identificação da fonte.

9. IMPORTAÇÃO DE ENERGIA DA REPÚBLICA ORIENTAL DO URUGUAI

9.1. República Oriental do Uruguai

Para a próxima semana operativa, foram declaradas as seguintes ofertas de importação de energia da República Oriental do Uruguai para o Sistema Interligado Nacional - SIN através da conversora de Melo (500 MW).

- **Enel**

Tabela 6 – Energia ofertada para importação

	Oferta de Energia para a Semana de 30/07 a 05/08 (MWmed)						
	Bloco 1	Bloco 2	Bloco 3	Bloco 4	Bloco 5	Bloco 6	Total
Carga Pesada	50	50	50	50	25	25	250
Carga Média	50	50	50	50	25	25	250
Carga Leve	50	50	50	50	25	25	250
CVU (R$/MWh)	538,67	826,30	1.791,84	2.017,14	2.866,82	3.175,79	

- **BTG Pactual**

Tabela 7 – Energia ofertada para importação

	Oferta de Energia para a Semana de 30/07 a 05/08 (MWmed)						
	Bloco 1	Bloco 2	Bloco 3	Bloco 4	Bloco 5	Bloco 6	Total
Carga Pesada	50	50	50	50	25	25	250
Carga Média	50	50	50	50	25	25	250
Carga Leve	50	50	50	50	25	25	250
CVU (R$/MWh)	534,53	822,64	1.783,02	2.007,11	2.852,24	3.159,56	

9.2. República da Argentina

Para esta semana operativa, não houve oferta de importação de energia da República da Argentina.

Nota: Detalhes sobre a importação de energia vide Portaria Nº 339, de 15 de agosto de 2018 disponível em: http://pesquisa.in.gov.br/imprensa/jsp/visualiza/index.jsp?data=17/08/2018&jornal=515&pagina=60&totalArquivos=136

O conteúdo desta publicação foi produzido pelo ONS com base em dados e informações de conhecimento público. É de responsabilidade exclusiva dos agentes e demais interessados a obtenção de outros dados e informações, a realização de análises, estudos e avaliações para fins de tomada de decisões, definição de estratégias de atuação, assunção de compromissos e obrigações e quaisquer outras finalidades, em qualquer tempo e sob qualquer condição. É proibida a reprodução ou utilização total ou parcial do presente sem a identificação da fonte.

10. ARMAZENAMENTOS OPERATIVOS

Para uma melhor avaliação de diversos cenários hidrometeorológicos, notadamente, aqueles de curto prazo e suas influências nas previsões de vazões nos subsistemas, os resultados deste PMO contemplam cenários de afluências visando melhor representar a ocorrência de precipitação e, consequentemente, seus efeitos sobre as afluências e armazenamentos.

Além dos resultados associados ao valor esperado das previsões de afluências, as simulações operativas também foram realizadas com os limites superior e inferior das previsões de afluências. Apresentamos a seguir as correspondentes energias naturais afluentes e os resultados obtidos com a aplicação dos diferentes cenários de afluência.

Tabela 8 – Previsão de ENA dos cenários de sensibilidade

Subsistema	ENERGIAS NATURAIS AFLUENTES					
	Previsão Mensal					
	LI		VE		LS	
	(MWmed)	%MLT	(MWmed)	%MLT	(MWmed)	%MLT
SE/CO	11.856	**58**	13.764	**67**	15.672	**76**
Sul	3.855	**39**	7.919	**80**	12.374	**125**
Nordeste	2.019	**61**	2.225	**67**	2.434	**73**
Norte	2.547	**80**	2.845	**89**	3.143	**99**

Tabela 9 – Previsão de %EARmáx para o final do mês

Subsistema	% EARmáx 29/07	% EARmáx - 31/08		
	NÍVEL INICIAL	NÍVEL PMO		
	VE	LI	VE	LS
SE/CO	61,5	52,4	53,1	54,5
Sul	77,6	64,1	72,6	79,7
Nordeste	83,5	70,1	75,9	78,1
Norte	89,2	89,8	89,8	89,9

O conteúdo desta publicação foi produzido pelo ONS com base em dados e informações de conhecimento público. É de responsabilidade exclusiva dos agentes e demais interessados a obtenção de outros dados e informações, a realização de análises, estudos e avaliações para fins de tomada de decisões, definição de estratégias de atuação, assunção de compromissos e obrigações e quaisquer outras finalidades, em qualquer tempo e sob qualquer condição. É proibida a reprodução ou utilização total ou parcial do presente sem a identificação da fonte.

11. RESERVATÓRIOS EQUIVALENTES DE ENERGIA

A seguir são apresentadas as previsões de Energia Natural Afluente para a próxima semana operativa e para o mês de agosto, bem como as previsões de Energia Armazenada nos Reservatórios Equivalentes de Energia – REE, deste PMO.

Tabela 10 – Previsão de ENA por REE

Valor Esperado das Energias Naturais Afluentes				
REE	Previsão Semanal		Previsão Mensal	
	30/07/2022 a 05/08/2022		ago/22	
	(MWmed)	%MLT	(MWmed)	%MLT
Sudeste	1.913	74	1.826	74
Madeira	1.802	64	1.540	64
Teles Pires	691	81	616	78
Itaipu	2.076	75	2.026	78
Paraná	7.230	65	6.871	66
Paranapanema	844	42	873	47
Sul	3.527	60	5.730	97
Iguaçu	1.755	41	2.189	54
Nordeste	2.333	68	2.225	67
Norte	1.513	74	1.329	72
Belo Monte	852	90	566	84
Manaus	1.290	166	995	147

Tabela 11 – Previsão de %EARmáx por REE

% Energia Armazenável Máxima		
REE	Previsão Semanal	Previsão Mensal
	05-ago	31-ago
	(%EARmáx)	(%EARmáx)
Sudeste	60,9	55,9
Madeira	57,0	50,3
Teles Pires	66,0	58,0
Itaipu	57,5	100,0
Paraná	60,1	51,8
Paranapanema	54,8	54,2
Sul	81,4	80,0
Iguaçu	69,5	65,5
Nordeste	81,5	75,9
Norte	89,0	89,9
Belo Monte	100,0	100,0
Manaus	90,3	88,5

O conteúdo desta publicação foi produzido pelo ONS com base em dados e informações de conhecimento público. É de responsabilidade exclusiva dos agentes e demais interessados a obtenção de outros dados e informações, a realização de análises, estudos e avaliações para fins de tomada de decisões, definição de estratégias de atuação, assunção de compromissos e obrigações e quaisquer outras finalidades, em qualquer tempo e sob qualquer condição. É proibida a reprodução ou utilização total ou parcial do presente sem a identificação da fonte.

12. DESPACHO TÉRMICO POR MODALIDADE, PATAMAR DE CARGA E USINA

Nas tabelas abaixo, a diferenciação entre geração por inflexibilidade e por ordem de mérito tem caráter informativo, com o objetivo de detalhar a informação de inflexibilidade enviada pelos respectivos agentes para o PMO. Ressalta-se que nas etapas de Programação Diária e Tempo Real, o montante despachado nas usinas termelétricas indicadas por ordem de mérito é plenamente intitulado como ordem de mérito.

REGIÃO SUDESTE/CENTRO-OESTE																	
Térmicas Potência (MW)	Combustível	CVU (R$/MWh)	Inflexibilidade			Ordem de Mérito			Total Mérito e INFL.			Razão Elétrica			Total UTE		
			P	M	L	P	M	L	P	M	L	P	M	L	P	M	L
ATLAN_CSA (255)	Resíduos	0,00	176,6	176,6	176,6				176,6	176,6	176,6				176,6	176,6	176,6
CUIABA CC (529)	Gás	0,00															
W.ARJONA O* (177)	Diesel	0,00															
ANGRA 2 (1350)	Nuclear	20,12	1350,0	1350,0	1350,0	0,0	0,0	0,0	1350,0	1350,0	1350,0				1350,0	1350,0	1350,0
ANGRA 1 (640)	Nuclear	31,17	640,0	640,0	640,0	0,0	0,0	0,0	640,0	640,0	640,0				640,0	640,0	640,0
NORTEFLU 1 (400)	Gás	97,41				400,0	400,0	400,0	400,0	400,0	400,0				400,0	400,0	400,0
NORTEFLU 2 (100)	Gás	113,65															
O.PINTADA (50)	Biomassa	124,48	30,0	23,0	14,0				30,0	23,0	14,0				30,0	23,0	14,0
UTE STA VI (41)	Biomassa	134,46	14,0	14,0	14,0				14,0	14,0	14,0				14,0	14,0	14,0
PREDILECTA (5)	Biomassa	175,91															
NORTEFLU 3 (200)	Gás	217,52															
ATLANTICO (235)	Resíduos	227,09	218,7	218,7	218,7				218,7	218,7	218,7				218,7	218,7	218,7
ST.CRUZ 34 (436)	Óleo	310,41															
T.LAGOAS (350)	Gás	318,54															
TERMORIO (989)	Gás	380,20															
CUBATAO (216)	Gás	392,78															
BAIXADA FL (530)	Gás	400,94															
SANTA CRUZ (500)	GNL	405,93															
SEROPEDICA (360)	Gás	468,21															
PIRAT.12 O (200)	Gás	470,34															
JUIZ DE FO (87)	Gás	522,96															
LUIZORMELO (204)	GNL	631,14															
NPIRATINGA (572)	Gás	654,42															
UTE GNA I (1338)	Gás	794,09															
T.MACAE (929)	Gás	885,63															
TNORTE 2 (349)	Óleo	910,86															
NORTEFLU 4 (127)	Gás	966,84															
CAMPOS (25)	Gás	978,10															
VIANA (175)	Óleo	1411,00															
PALMEIR_GO (176)	Diesel	1495,97															
IBIRITE (235)	Gás	1645,00															
DAIA (44)	Diesel	1831,16															
GOIANIA 2 (140)	Diesel	1931,55															
W.ARJONA* (177)	Gás	2326,88															
XAVANTES (54)	Diesel	2637,13															
PAULINIA (16)	Gás	2744,88	15,7	15,7	15,7				15,7	15,7	15,7				15,7	15,7	15,7
LORM_PCS (36)	Gás	2876,82	34,5	34,5	34,5				34,5	34,5	34,5				34,5	34,5	34,5
POVOACAO I (75)	Gás	2876,82	55,1	55,1	55,1				55,1	55,1	55,1				55,1	55,1	55,1
VIANA I (37)	Gás	2876,82	36,5	36,5	36,5				36,5	36,5	36,5				36,5	36,5	36,5
TOTAL SE/CO (12183)			2571,1	2564,1	2555,1	400,0	400,0	400,0	2971,1	2964,1	2955,1	0,0	0,0	0,0	2971,1	2964,1	2955,1

REGIÃO SUL																	
Térmicas Potência (MW)	Combustível	CVU (R$/MWh)	Inflexibilidade			Ordem de Mérito			Total Mérito e INFL.			Razão Elétrica			Total UTE		
			P	M	L	P	M	L	P	M	L	P	M	L	P	M	L
ARAUCARIA (484)	Gás	---															
URUGUAIANA (640)	Gás	---															
PAMPA SUL (345)	Carvão	77,19				345,0	261,4	161,0	345,0	261,4	161,0				345,0	261,4	161,0
SAO SEPE (8)	Biomassa	97,11	7,0	7,0	7,0	0,0	0,0	0,0	7,0	7,0	7,0				7,0	7,0	7,0
CANDIOTA_3 (350)	Carvão	101,78	270,0	270,0	270,0				270,0	270,0	270,0				270,0	270,0	270,0
J.LACER. C (363)	Carvão	285,18															
J.LACER. B (262)	Carvão	331,67															
J.LAC. A2 (132)	Carvão	333,15															
MADEIRA (4)	Biomassa	360,51	2,0	2,0	2,0				2,0	2,0	2,0				2,0	2,0	2,0
J.LAC. A1 (100)	Carvão	392,82															
FIGUEIRA (20)	Carvão	475,68															
CANOAS (249)	Diesel	698,14															
TOTAL SUL (2957)			279,0	279,0	279,0	345,0	261,4	161,0	624,0	540,4	440,0	0,0	0,0	0,0	624,0	540,4	440,0

*Conforme Resolução Autorizativa ANEEL nº 10.422/2021, a UTE William Arjona pode operar com óleo diesel, como combustível alternativo.

O conteúdo desta publicação foi produzido pelo ONS com base em dados e informações de conhecimento público. É de responsabilidade exclusiva dos agentes e demais interessados a obtenção de outros dados e informações, a realização de análises, estudos e avaliações para fins de tomada de decisões, definição de estratégias de atuação, assunção de compromissos e obrigações e quaisquer outras finalidades, em qualquer tempo e sob qualquer condição. É proibida a reprodução ou utilização total ou parcial do presente sem a identificação da fonte.

REGIÃO NORDESTE

Térmicas Potência (MW)	Combustível	CVU (R$/MWh)	Inflexibilidade			Ordem de Mérito			Total Mérito e INFL.			Razão Elétrica			Total UTE		
			P	M	L	P	M	L	P	M	L	P	M	L	P	M	L
ALTOS (13)	Diesel	---															
ARACATI (11)	Diesel	---															
BATURITE (11)	Diesel	---															
C.MAIOR (13)	Diesel	---															
CAUCAIA (15)	Diesel	---															
CRATO (13)	Diesel	---															
IGUATU (15)	Diesel	---															
JUAZEIRO N (15)	Diesel	---															
MARAMBAIA (13)	Diesel	---															
NAZARIA (13)	Diesel	---															
PECEM (15)	Diesel	---															
ERB CANDEI (17)	Biomassa	97,18	4,5	4,5	4,5	6,5	6,5	6,5	11,0	11,0	11,0				11,0	11,0	11,0
PROSPERIDA (28)	Gás	183,28															
TERMOPE (533)	Gás	236,80															
FORTALEZA (327)	Gás	277,36															
T.BAHIA (186)	Gás	374,87															
VALE ACU (368)	Gás	450,86															
TERMOCEARA (223)	Gás	479,75															
PSERGIPE I (1593)	GNL	500,85															
SYKUE I (30)	Biomassa	510,12															
P.PECEM2 (365)	Carvão	1017,94	25,0	35,0	25,0				25,0	35,0	25,0				25,0	35,0	25,0
P.PECEM1 (720)	Carvão	1051,83															
PERNAMBU_3 (201)	Óleo	1226,48															
MARACANAU (168)	Óleo	1378,57															
TERMOCABO (50)	Óleo	1393,43															
TERMONE (171)	Óleo	1394,43															
TERMOPB (171)	Óleo	1394,43															
CAMPINA_GR (169)	Óleo	1411,02															
SUAPE II (381)	Óleo	1457,43															
BAHIA I (31)	Óleo	1495,67															
GLOBAL I (149)	Óleo	1597,12															
GLOBAL II (149)	Óleo	1597,12															
AREMBEPE (150)	Óleo	1839,87															
MURICY (147)	Óleo	1839,87															
PETROLINA (136)	Óleo	2018,59															
POTIGUAR_3 (66)	Diesel	2034,41															
POTIGUAR (53)	Diesel	2034,43															
PAU FERRO (94)	Diesel	2278,98															
TERMOMANAU (143)	Diesel	2278,98															
TOTAL NE (6966)			29,5	39,5	29,5	6,5	6,5	6,5	36,0	46,0	36,0	0,0	0,0	0,0	36,0	46,0	36,0

REGIÃO NORTE

Térmicas Potência (MW)	Combustível	CVU (R$/MWh)	Inflexibilidade			Ordem de Mérito			Total Mérito e INFL.			Razão Elétrica			Total UTE		
			P	M	L	P	M	L	P	M	L	P	M	L	P	M	L
C. ROCHA (85)	Gás	0,00	65,0	65,0	65,0				65,0	65,0	65,0				65,0	65,0	65,0
JARAQUI (75)	Gás	0,00	63,0	63,0	63,0				63,0	63,0	63,0				63,0	63,0	63,0
MANAUARA (67)	Gás	0,00	64,0	64,0	64,0				64,0	64,0	64,0				64,0	64,0	64,0
PONTA NEGR (73)	Gás	0,00	64,0	64,0	64,0				64,0	64,0	64,0				64,0	64,0	64,0
TAMBAQUI (93)	Gás	0,00	63,0	63,0	63,0				63,0	63,0	63,0				63,0	63,0	63,0
MARANHAO3 (519)	Gás	94,86	490,0	490,0	490,0	4,8	25,3	22,7	494,8	515,3	512,7				494,8	515,3	512,7
PARNAIB_IV (56)	Gás	151,69	15,0	15,0	15,0				15,0	15,0	15,0				15,0	15,0	15,0
APARECIDA (166)	Gás	176,75	75,0	75,0	75,0				75,0	75,0	75,0				75,0	75,0	75,0
UTE MAUA 3 (591)	Gás	176,75	264,0	264,0	264,0				264,0	264,0	264,0				264,0	264,0	264,0
N.VEN2_L22 (27)	Gás	257,06	12,0	12,0	12,0				12,0	12,0	12,0				12,0	12,0	12,0
N.VEN2_L7 (151)	Gás	257,06	45,0	45,0	45,0				45,0	45,0	45,0				45,0	45,0	45,0
MARAN_VL_7 (336)	Gás	370,83	250,0	90,0	50,0				250,0	90,0	50,0				250,0	90,0	50,0
MARANIVL_7 (336)	Gás	370,83	260,0	100,0	55,0				260,0	100,0	55,0				260,0	100,0	55,0
MARAN_VL22 (1)	Gás	370,84	1,0	1,0	1,0				1,0	1,0	1,0				1,0	1,0	1,0
MARANIVL22 (1)	Gás	370,84	1,0	1,0	1,0				1,0	1,0	1,0				1,0	1,0	1,0
P. ITAQUI (360)	Carvão	1007,51															
GERAMAR1 (166)	Óleo	1410,97															
GERAMAR2 (166)	Óleo	1410,97															
TOTAL NORTE (3271)			1732,0	1412,0	1327,0	4,8	25,3	22,7	1736,8	1437,3	1349,7	0,0	0,0	0,0	1736,8	1437,3	1349,7

O conteúdo desta publicação foi produzido pelo ONS com base em dados e informações de conhecimento público. É de responsabilidade exclusiva dos agentes e demais interessados a obtenção de outros dados e informações, a realização de análises, estudos e avaliações para fins de tomada de decisões, definição de estratégias de atuação, assunção de compromissos e obrigações e quaisquer outras finalidades, em qualquer tempo e sob qualquer condição. É proibida a reprodução ou utilização total ou parcial do presente sem a identificação da fonte.