1. APRESENTAÇÃO

Na semana de 05/09 a 11/09 ocorreu chuva fraca nas bacias dos rios Jacuí e Uruguai. Nas demais bacias hidrográficas de interesse do SIN manteve-se a ausência de precipitação.

Na semana de 12/09 a 18/09 será mantida a condição de precipitação nas bacias dos rios Jacuí e Uruguai.

Para a semana operativa de 12/09 a 18/09/2020, houve oferta de energia da República Oriental do Uruguai. De acordo com o Art. 2º da Portaria MME nº 339, de 15 de agosto de 2018, as ofertas para importação de energia não foram consideradas na elaboração do PMO. Para a referida semana, não houve oferta de energia da República da Argentina.

Os valores médios semanais do Custo Marginal de Operação – CMO dos subsistemas do SIN sofreram as seguintes alterações em relação à semana anterior:

- SE/CO: de R$ 70,47/MWh para R$ 83,66/MWh
- Sul: de R$ 70,47/MWh para R$ 83,66/MWh
- Nordeste: de R$ 53,90/MWh para R$ 61,54/MWh
- Norte: de R$ 70,47/MWh para R$ 83,66/MWh

Desde o dia 01/01/2020, o despacho por ordem de mérito é indicado diariamente pelos resultados do modelo DESSEM. Assim, o despacho por ordem de mérito semanal, conforme publicado nesse documento, tem caráter apenas informativo.

2. NOTÍCIAS

Nos dias 24 e 25 de setembro será realizada a reunião de elaboração do PMO Outubro de 2020, com transmissão ao vivo através do site do ONS.

Como medida adicional de prevenção ao Coronavírus, o ONS informa que está suspensa, temporariamente, a participação presencial nas reuniões.

3. ANÁLISE DAS CONDIÇÕES HIDROMETEOROLÓGICAS

3.1 PREVISÃO PARA A PRÓXIMA SEMANA

A atuação do sistema de baixa pressão no Paraguai e o avanço de duas frentes frias pelo estado do Rio Grande do Sul e litoral de Santa Catarina e do Paraná mantêm a condição de precipitação nas bacias dos rios Jacuí e Uruguai na próxima semana **(Figura 1).**

O conteúdo desta publicação foi produzido pelo ONS com base em dados e informações de conhecimento público. É de responsabilidade exclusiva dos agentes e demais interessados a obtenção de outros dados e informações, a realização de análises, estudos e avaliações para fins de tomada de decisões, definição de estratégias de atuação, assunção de compromissos e obrigações e quaisquer outras finalidades, em qualquer tempo e sob qualquer condição. É proibida a reprodução ou utilização total ou parcial do presente sem a identificação da fonte.

Figura 1 - Precipitação acumulada prevista pelo modelo GEFS (CPTEC/INPE) para o período de 12 a 18/09/2020

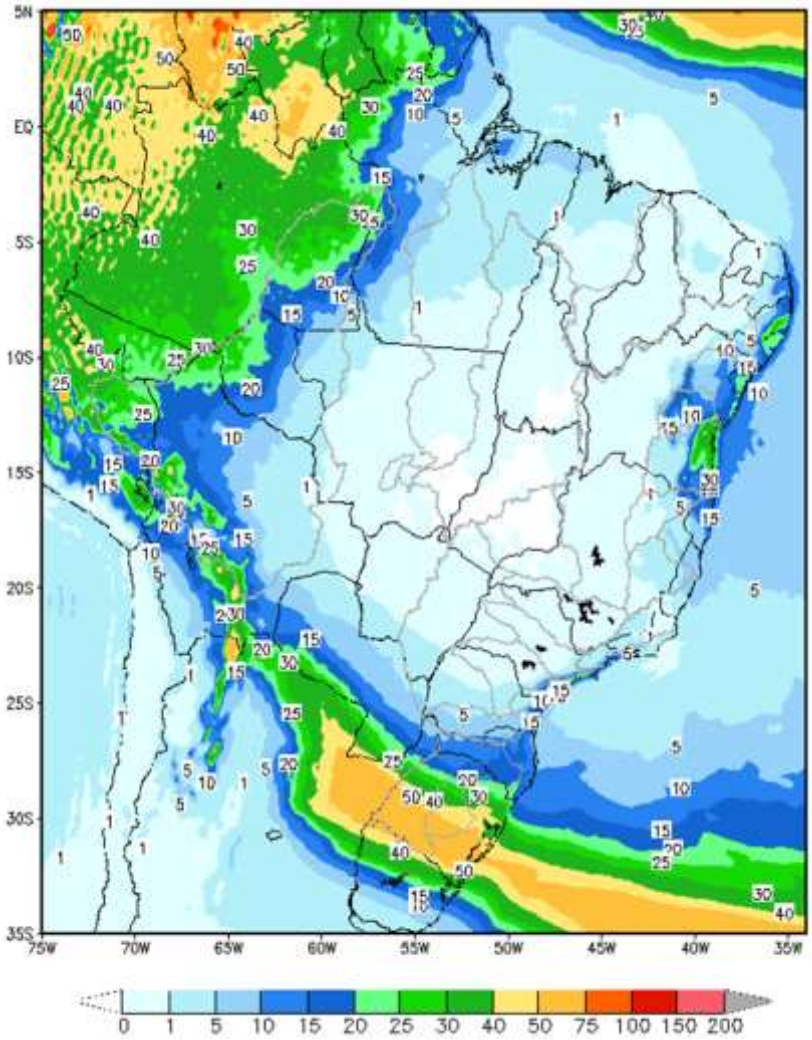

Em comparação com os valores estimados para a semana em curso, prevê-se para a próxima semana operativa recessão nas afluências dos subsistemas Sudeste, Sul e Norte e estabilidade no subsistema Nordeste.

A previsão mensal para setembro indica a ocorrência de afluências abaixo da média histórica para todos os subsistemas.

Tabela 1 – Previsão de ENAs da revisão 2 do PMO de setembro/2020

Revisão 2 do PMO de Setembro/2020 - ENAs previstas				
Subsistema	12/9 a 18/9/2020		Mês de Setembro	
	MWmed	%MLT	MWmed	%MLT
SE/CO	12.898	65	14.233	72
S	5.539	47	6.940	59
NE	2.003	67	2.027	68
N	1.520	66	1.630	71

O conteúdo desta publicação foi produzido pelo ONS com base em dados e informações de conhecimento público. É de responsabilidade exclusiva dos agentes e demais interessados a obtenção de outros dados e informações, a realização de análises, estudos e avaliações para fins de tomada de decisões, definição de estratégias de atuação, assunção de compromissos e obrigações e quaisquer outras finalidades, em qualquer tempo e sob qualquer condição. É proibida a reprodução ou utilização total ou parcial do presente sem a identificação da fonte.

4. PREVISÃO DE CARGA

As sondagens disponibilizadas pela Fundação Getúlio Vargas - FGV (indústria, serviços, comércio e construção civil), ratificam a premissa considerada na consolidação das previsões de carga durante o mês de setembro, que se baseiam na continuidade do processo de retomada das atividades econômicas no país. Durante as primeiras semanas operativas do mês em análise, o comportamento da carga observado vem sendo impactado pelo ritmo dessa retomada, além dos efeitos provocados pela elevação das temperaturas em grande parte das capitais, mesmo ainda no período de inverno.

Para a próxima semana operativa as sinalizações meteorológicas indicam manutenção das temperaturas em níveis elevados nas capitais na região Sudeste/Centro-Oeste.

No subsistema Sul, para as capitais do Rio Grande do Sul e Florianópolis há expectativa de elevação das temperaturas para a próxima semana operativa. Curitiba segue com comportamento estável em relação às últimas semanas.

Para os subsistemas Nordeste e Norte a sinalização meteorológica indica ocorrência de temperaturas e precipitação semelhantes às observadas na semana vigente, comportamento típico para a época do ano.

As variações previstas para o mês de setembro em relação ao mesmo mês de 2019, são de 1,3% no subsistema Sudeste/Centro-Oeste, 5,8% para o subsistema Sul, -0,5% para o subsistema Nordeste e 5,4% no subsistema Norte.

Ressalta-se no subsistema Norte, a retomada de carga de um consumidor livre da rede básica que estava com consumo reduzido desde março de 2020.

Tabela 2 – Evolução da carga do PMO de setembro/2020

Subsistema	CARGA SEMANAL (MWmed)					CARGA MENSAL (MWmed)	
	1ª Sem	2ª Sem	3ª Sem	4ª Sem	5ª Sem	set/20	Var. (%) set/20 -> set/19
Sudeste	39.204	39.908	40.079	40.118	40.180	39.948	1,3%
Sul	11.564	11.306	11.660	11.670	11.681	11.570	5,8%
Nordeste	10.605	10.526	10.659	10.701	10.712	10.639	-0,5%
Norte	5.979	6.010	6.093	6.090	6.086	6.056	5,4%
SIN	67.352	67.750	68.491	68.579	68.659	68.213	2,1%

O conteúdo desta publicação foi produzido pelo ONS com base em dados e informações de conhecimento público. É de responsabilidade exclusiva dos agentes e demais interessados a obtenção de outros dados e informações, a realização de análises, estudos e avaliações para fins de tomada de decisões, definição de estratégias de atuação, assunção de compromissos e obrigações e quaisquer outras finalidades, em qualquer tempo e sob qualquer condição. É proibida a reprodução ou utilização total ou parcial do presente sem a identificação da fonte.

5. PRINCIPAIS RESULTADOS

5.1 CUSTO MARGINAL DE OPERAÇÃO (CMO)

A tabela a seguir apresenta o CMO, por subsistema e patamar de carga para próxima semana operativa.

Tabela 3 – CMO por patamar de carga

Patamares de Carga	CMO (R$/MWh)			
	SE/CO	S	NE	N
Pesada	85,64	85,64	64,06	85,64
Média	84,08	84,08	62,38	84,08
Leve	82,23	82,23	59,57	82,23
Média Semanal	83,66	83,66	61,54	83,66

Na figura a seguir é apresentada a evolução do CMO médio semanal ao longo deste PMO.

Figura 2 – Evolução semanal do CMO

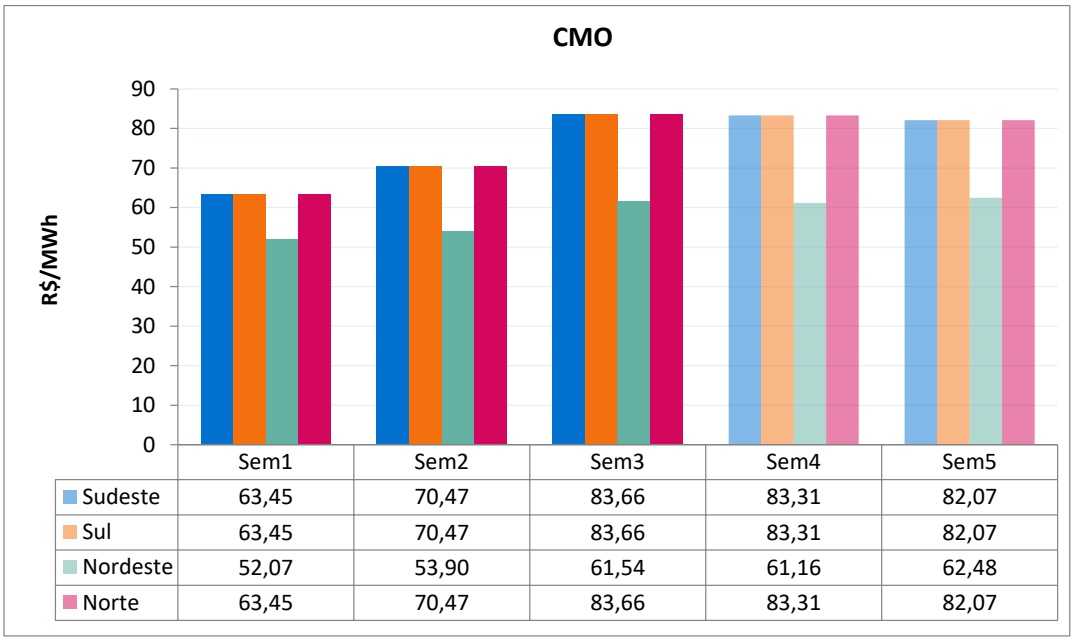

5.2 POLÍTICA DE OPERAÇÃO ENERGÉTICA

Para esta semana operativa, está prevista a seguinte política de intercâmbio de energia entre regiões:

Região SE/CO → Geração dimensionada para fechamento do balanço energético do SIN.

Região Sul → Geração dimensionada de forma a otimizar os recursos desta região.

Região NE → Intercâmbio de energia definido em função dos recursos energéticos da região, respeitando-se os limites elétricos vigentes para o subsistema.

Região Norte → Geração dimensionada de forma a otimizar os recursos desta região e buscando-se a aderência a curva guia para o armazenamento da UHE Tucuruí.

O conteúdo desta publicação foi produzido pelo ONS com base em dados e informações de conhecimento público. É de responsabilidade exclusiva dos agentes e demais interessados a obtenção de outros dados e informações, a realização de análises, estudos e avaliações para fins de tomada de decisões, definição de estratégias de atuação, assunção de compromissos e obrigações e quaisquer outras finalidades, em qualquer tempo e sob qualquer condição. É proibida a reprodução ou utilização total ou parcial do presente sem a identificação da fonte.

6. ANÁLISE DA VARIAÇÃO SEMANAL DO CMO

Esta análise visa identificar os principais parâmetros cujas atualizações impactaram os CMO desta revisão do PMO, em comparação com os valores obtidos na revisão anterior.

Foram realizados 8 estudos, onde caso inicial foi construído com base nos dados oficiais da última revisão deste PMO. Neste primeiro estudo a partida dos reservatórios foi estimada conforme indicado para esta semana na última revisão.

O segundo estudo foi realizado com os dados do caso inicial sendo substituída previsão de vazões para esta revisão.

A partir do conjunto de dados do segundo estudo foram elaborados os demais casos onde foram atualizados, sequencialmente, as seguintes informações: níveis de partida dos reservatórios, previsão de carga, disponibilidade das usinas, limites elétricos, restrições hidráulicas e por fim os demais dados que compõe toda a informação referente a atual revisão.

Os principais fatores que influenciaram na elevação do CMO nos subsistemas do Sudeste/Centro-Oeste, Sul e Norte foram as atualizações da previsão de vazões e previsão de carga além dos níveis de partida.

Figura 3 – Análise da variação do CMO nos subsistemas SE/CO, Sul e Norte

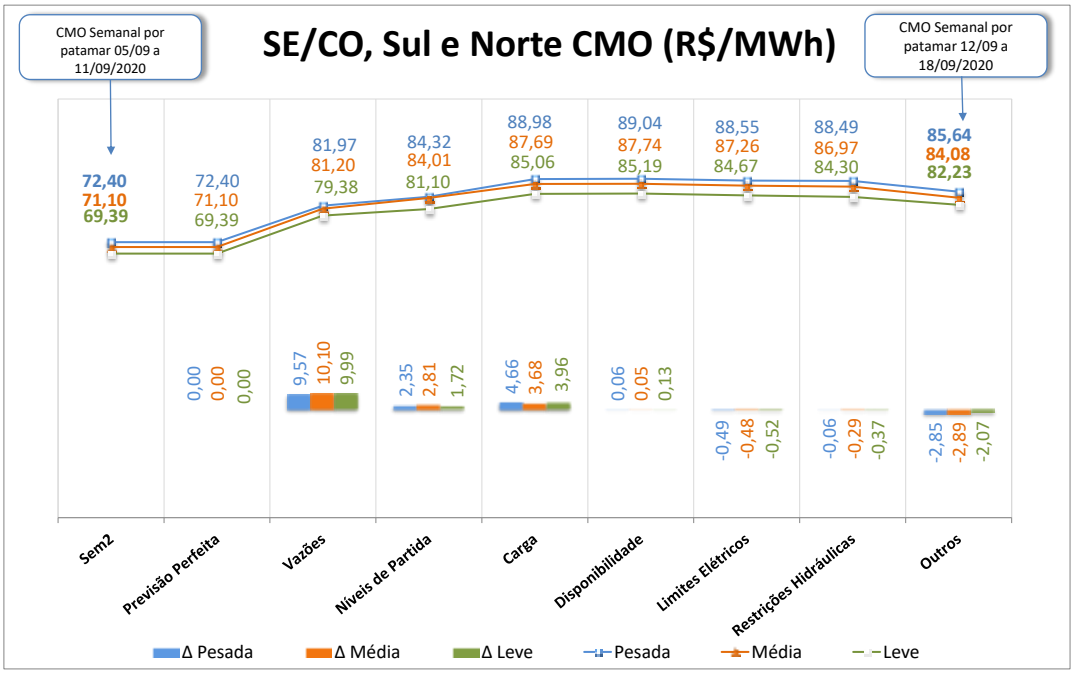

O conteúdo desta publicação foi produzido pelo ONS com base em dados e informações de conhecimento público. É de responsabilidade exclusiva dos agentes e demais interessados a obtenção de outros dados e informações, a realização de análises, estudos e avaliações para fins de tomada de decisões, definição de estratégias de atuação, assunção de compromissos e obrigações e quaisquer outras finalidades, em qualquer tempo e sob qualquer condição. É proibida a reprodução ou utilização total ou parcial do presente sem a identificação da fonte.

No subsistema Nordeste, o principal fator que influenciou na elevação do CMO foi a atualizações da previsão de vazões.

Figura 4 – Análise da variação do CMO no subsistema Nordeste

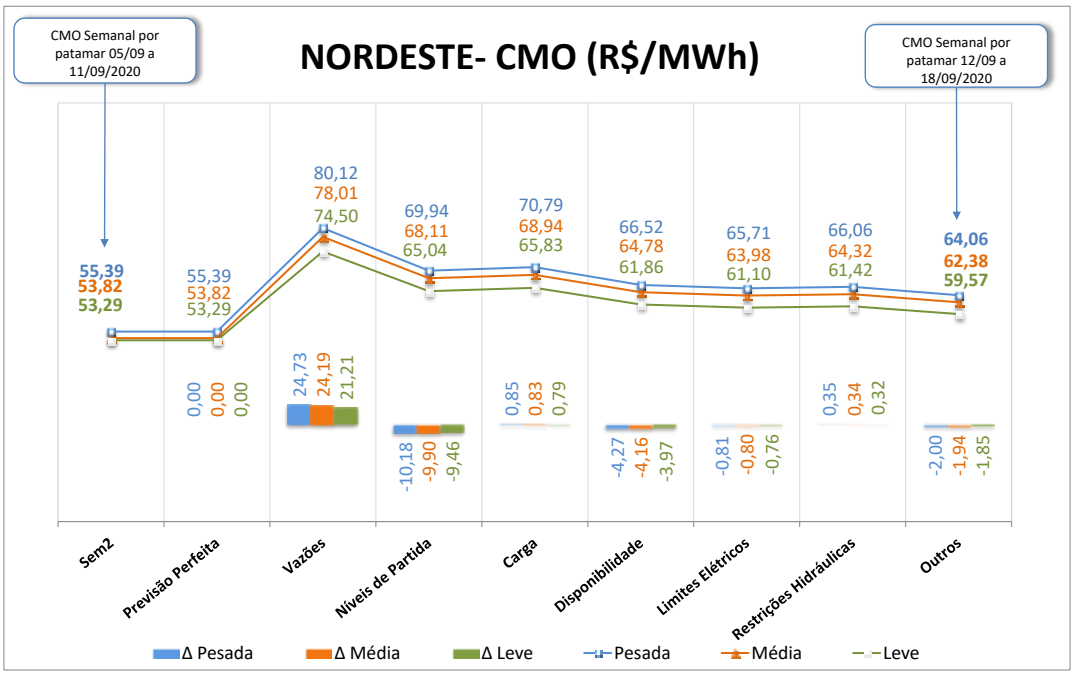

7. GERAÇÃO TÉRMICA

A **Figura 5** apresenta, para cada subsistema, o despacho térmico por modalidade, para a próxima semana operativa.

Figura 5 – Geração térmica para a próxima semana operativa

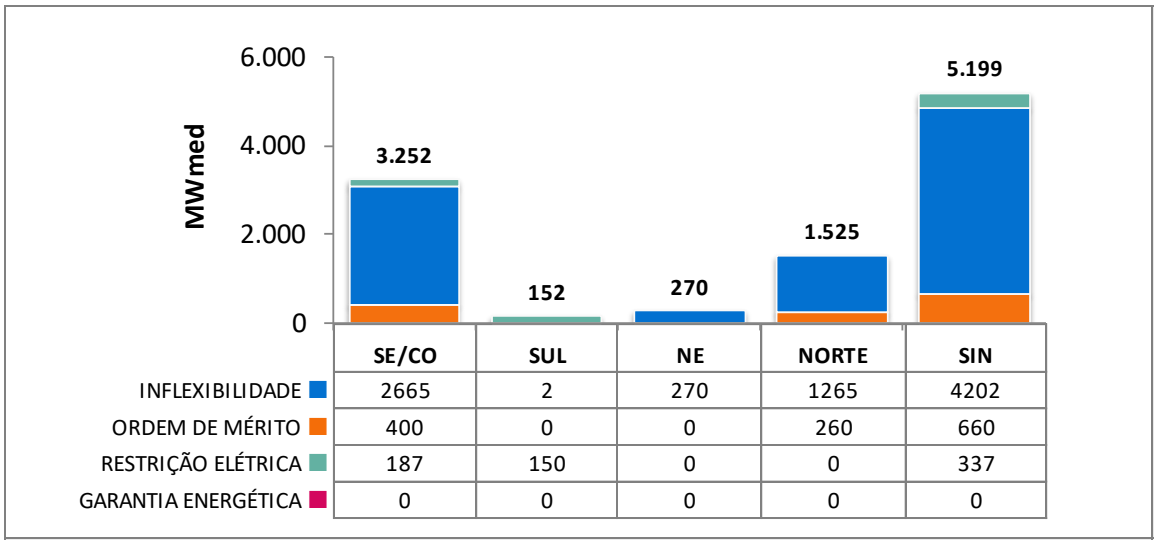

	SE/CO	SUL	NE	NORTE	SIN
INFLEXIBILIDADE	2665	2	270	1265	4202
ORDEM DE MÉRITO	400	0	0	260	660
RESTRIÇÃO ELÉTRICA	187	150	0	0	337
GARANTIA ENERGÉTICA	0	0	0	0	0

Na tabela abaixo segue a Indicação de despacho antecipado por ordem de mérito de custo para a semana de 14/11 a 20/11/2020.

O conteúdo desta publicação foi produzido pelo ONS com base em dados e informações de conhecimento público. É de responsabilidade exclusiva dos agentes e demais interessados a obtenção de outros dados e informações, a realização de análises, estudos e avaliações para fins de tomada de decisões, definição de estratégias de atuação, assunção de compromissos e obrigações e quaisquer outras finalidades, em qualquer tempo e sob qualquer condição. É proibida a reprodução ou utilização total ou parcial do presente sem a identificação da fonte.

Tabela 4 – UTEs com contrato de combustível GNL

UTE			Benefício (R$/MWh)		
Nome	Cod	CVU (R$/MWh)	Carga Pesada	Carga Média	Carga Leve
SANTA CRUZ	86	178,56	70,85 (2)	70,85 (2)	70,84 (2)
LUIZORMELO	15	270,71	70,85 (2)	70,85 (2)	70,84 (2)
PSERGIPE I	224	214,84	62,50 (2)	60,14 (2)	60,14 (2)

(1) Comandado o despacho antecipado por ordem de mérito de custo nesse patamar

(2) NÃO foi comandado o despacho antecipado por ordem de mérito de custo nesse patamar

Apesar da UTE Luiz O. R. Melo não estar despachada por ordem de mérito, há necessidade do despacho de, pelo menos, 204 MW dessa usina para reduzir o risco de corte de carga na região de Governador Valadares e na região Norte do Espírito Santo. Desta forma, a UTE Luiz O. R. Melo deverá ser despachada por razão elétrica, na referida semana, em 204 MW.

8. IMPORTAÇÃO DE ENERGIA DA REPÚBLICA ORIENTAL DO URUGUAI

7.1 República Oriental do Uruguai

Para a próxima semana operativa, foram declaradas as seguintes ofertas de importação de energia da República Oriental do Uruguai para o Sistema Interligado Nacional - SIN através das conversoras de Rivera (70 MW) e Melo (500 MW).

- **Eletrobras**

Tabela 5 – Energia Ofertada para Importação

	Oferta de Energia para a Semana de 12/9 a 18/9 (MWmed)			
	Bloco 1	Bloco 2	Bloco 3	Total
Carga Pesada	70,0	60,0	190,0	320,0
Carga Média	70,0	60,0	190,0	320,0
Carga Leve	70,0	60,0	190,0	320,0
CVU (R$/MWh)	205,31	320,50	714,24	

- **Enel**

Conforme declaração do agente, esta importação poderá ser realizada exclusivamente pela conversora Melo.

Tabela 6 – Energia Ofertada para Importação

	Oferta de Energia para a Semana de 12/9 a 18/9 (MWmed)		
	Bloco 1	Bloco 2	Total
Carga Pesada	60,0	190,0	250,0
Carga Média	60,0	190,0	250,0
Carga Leve	60,0	190,0	250,0
CVU (R$/MWh)	324,68	722,30	

O conteúdo desta publicação foi produzido pelo ONS com base em dados e informações de conhecimento público. É de responsabilidade exclusiva dos agentes e demais interessados a obtenção de outros dados e informações, a realização de análises, estudos e avaliações para fins de tomada de decisões, definição de estratégias de atuação, assunção de compromissos e obrigações e quaisquer outras finalidades, em qualquer tempo e sob qualquer condição. É proibida a reprodução ou utilização total ou parcial do presente sem a identificação da fonte.

7.2 República da Argentina

Para esta semana operativa, não houve oferta de importação de energia da República da Argentina.

Nota: Detalhes sobre a importação de energia vide Portaria Nº 339, de 15 de Agosto de 2018 disponível em: http://pesquisa.in.gov.br/imprensa/jsp/visualiza/index.jsp?data=17/08/2018&jornal=515&pagina=60&totalArquivos=136

9. ESTIMATIVA DE ENCARGOS OPERATIVOS

A tabela a seguir apresenta a expectativa do custo de despacho térmico por restrição elétrica para esta semana operativa.

Tabela 7 – Expectativa de custo de despacho térmico por Restrição Elétrica

UTE Potência Instalada (MW)	CVU (R$/MWh)	Geração (MWmed)			ESS ELÉTRICO
		Carga Pesada	Carga Média	Carga Leve	
LUIZORMELO (204)	R$ 270,71	187,0	187,0	187,0	**R$ 5.876.258,03**
TOTAL SE/CO					**R$ 5.876.258,03**

10. ARMAZENAMENTOS OPERATIVOS

Para uma melhor avaliação de diversos cenários hidrometeorológicos, notadamente, aqueles de curto prazo e suas influências nas previsões de vazões nos subsistemas, os resultados desta revisão do PMO contemplam cenários de afluências visando melhor representar a ocorrência de precipitação e, consequentemente, seus efeitos sobre as afluências e armazenamentos.

Além dos resultados associados ao valor esperado das previsões de afluências, as simulações operativas também foram realizadas com os limites superior e inferior das previsões de afluências. Apresentamos a seguir os resultados obtidos com a aplicação dos diferentes cenários de afluência.

Tabela 8 – Previsão de ENA dos cenários de sensibilidade

Subsistema	ENERGIAS NATURAIS AFLUENTES					
	Previsão Mensal					
	LI		VE		LS	
	(MWmed)	%MLT	(MWmed)	%MLT	(MWmed)	%MLT
Sudeste	12.644	**64**	14.233	**72**	15.890	**80**
Sul	4.385	**37**	6.984	**59**	9.590	**81**
Nordeste	1.913	**64**	2.027	**68**	2.141	**72**
Norte	1.480	**64**	1.630	**71**	1.780	**78**

O conteúdo desta publicação foi produzido pelo ONS com base em dados e informações de conhecimento público. É de responsabilidade exclusiva dos agentes e demais interessados a obtenção de outros dados e informações, a realização de análises, estudos e avaliações para fins de tomada de decisões, definição de estratégias de atuação, assunção de compromissos e obrigações e quaisquer outras finalidades, em qualquer tempo e sob qualquer condição. É proibida a reprodução ou utilização total ou parcial do presente sem a identificação da fonte.

Tabela 9 – Previsão de %EARmáx para o final do mês

Subsistema	% EARmáx 11/9	% EARmáx - 30/9		
	NÍVEL INICIAL	NÍVEL PMO		
	VE	LI	VE	LS
Sudeste	39,2	33,8	35,0	35,9
Sul	58,2	38,9	46,7	54,4
Nordeste	72,4	63,1	63,4	63,7
Norte	62,0	51,8	52,0	52,2

11. RESERVATÓRIOS EQUIVALENTES DE ENERGIA

A seguir são apresentadas as previsões de Energia Natural Afluente para a próxima semana operativa e para o mês de setembro, bem como as previsões de Energia Armazenada nos Reservatórios Equivalentes de Energia – REE, desta revisão do PMO.

Tabela 10 – Previsão de ENA por REE

Valor Esperado das Energias Naturais Afluentes				
REE	Previsão Semanal		Previsão Mensal	
	12/09/2020 a 18/09/2020		set/20	
	(MWmed)	%MLT	(MWmed)	%MLT
Sudeste	1.533	63	1.665	68
Madeira	1.694	94	1.806	100
Teles Pires	467	68	485	71
Itaipu	2.160	81	2.651	99
Paraná	6.081	60	6.473	64
Paranapanema	964	47	1.162	56
Sul	3.897	56	4.523	65
Iguaçu	1.642	34	2.461	51
Nordeste	2.003	67	2.027	68
Norte	825	55	911	61
Belo Monte	233	62	244	64
Manaus	473	110	494	115

O conteúdo desta publicação foi produzido pelo ONS com base em dados e informações de conhecimento público. É de responsabilidade exclusiva dos agentes e demais interessados a obtenção de outros dados e informações, a realização de análises, estudos e avaliações para fins de tomada de decisões, definição de estratégias de atuação, assunção de compromissos e obrigações e quaisquer outras finalidades, em qualquer tempo e sob qualquer condição. É proibida a reprodução ou utilização total ou parcial do presente sem a identificação da fonte.

Tabela 11 – Previsão de %EARmáx por REE

% Energia Armazenável Máxima		
REE	Previsão Semanal	Previsão Mensal
	18-set	30-set
	(%EARmáx)	(%EARmáx)
Sudeste	36,5	33,9
Madeira	35,0	29,8
Teles Pires	8,0	5,7
Itaipu	41,0	86,3
Paraná	37,4	34,4
Paranapanema	45,3	46,2
Sul	65,0	60,2
Iguaçu	42,3	34,5
Nordeste	69,0	63,4
Norte	59,0	52,2
Belo Monte	95,5	89,8
Manaus	45,3	45,4

O conteúdo desta publicação foi produzido pelo ONS com base em dados e informações de conhecimento público. É de responsabilidade exclusiva dos agentes e demais interessados a obtenção de outros dados e informações, a realização de análises, estudos e avaliações para fins de tomada de decisões, definição de estratégias de atuação, assunção de compromissos e obrigações e quaisquer outras finalidades, em qualquer tempo e sob qualquer condição. É proibida a reprodução ou utilização total ou parcial do presente sem a identificação da fonte.

12. DESPACHO TÉRMICO POR MODALIDADE, PATAMAR DE CARGA E USINA

Nas tabelas abaixo, a diferenciação entre geração por inflexibilidade e por ordem de mérito tem caráter informativo, com o objetivo de detalhar a informação de inflexibilidade enviada pelos respectivos agentes para esta revisão do PMO. Ressalta-se que nas etapas de Programação Diária e Tempo Real, o montante despachado nas usinas termelétricas indicadas por ordem de mérito é plenamente intitulado como ordem de mérito.

REGIÃO SUDESTE/CENTRO-OESTE																	
Combustível	Combustível	CVU (R$/MWh)	Inflexibilidade			Ordem de Mérito			Total Mérito e INFL.			Razão Elétrica			Total UTE		
			P	M	L	P	M	L	P	M	L	P	M	L	P	M	L
ATLAN_CSA (255)	Resíduos	0,00	177,6	177,6	177,6				177,6	177,6	177,6				177,6	177,6	177,6
ANGRA 2 (1350)	Nuclear	20,12	1220,0	1220,0	1220,0	0,0	0,0	0,0	1220,0	1220,0	1220,0				1220,0	1220,0	1220,0
ANGRA 1 (640)	Nuclear	31,17	640,0	640,0	640,0	0,0	0,0	0,0	640,0	640,0	640,0				640,0	640,0	640,0
NORTEFLU 1 (400)	Gás	79,32				400,0	400,0	400,0	400,0	400,0	400,0				400,0	400,0	400,0
NORTEFLU 2 (100)	Gás	90,39															
UTE STA VI (41)	Biomassa	116,91	14,0	14,0	14,0				14,0	14,0	14,0				14,0	14,0	14,0
BAIXADA FL (530)	Gás	158,04															
NORTEFLU 3 (200)	Gás	172,92															
SANTA CRUZ (500)	GNL	178,56															
ATLANTICO (235)	Resíduos	192,70	218,7	218,7	218,7				218,7	218,7	218,7				218,7	218,7	218,7
T.LAGOAS (350)	Gás	224,40															
TERMORIO (1036)	Gás	267,67	270,0	270,0	270,0				270,0	270,0	270,0				270,0	270,0	270,0
LUIZORMELO (204)	GNL	270,71										187,0	187,0	187,0	187,0	187,0	187,0
JUIZ DE FO (87)	Gás	283,74															
CUIABA CC (529)	Gás	309,71															
ST.CRUZ 34 (436)	Óleo	310,41															
CUBATAO (216)	Gás	334,39	125,0	125,0	125,0				125,0	125,0	125,0				125,0	125,0	125,0
SEROPEDICA (386)	Gás	343,54															
IBIRITE (226)	Gás	346,37															
NORTEFLU 4 (127)	Gás	397,91															
PIRAT.12 O (200)	Gás	470,34															
NPIRATINGA (572)	Gás	548,04															
T.MACAE (929)	Gás	611,98															
VIANA (175)	Óleo	672,98															
TNORTE 2 (340)	Óleo	910,86															
PALMEIR_GO (176)	Diesel	924,82															
IGARAPE (131)	Óleo	939,55															
CAMPOS (25)	Gás	978,10															
DAIA (44)	Diesel	1178,62															
GOIANIA 2 (140)	Diesel	1235,75															
XAVANTES (54)	Diesel	1695,10															
TOTAL SE/CO (10634)			2665,30	2665,30	2665,30	400,0	400,0	400,0	3065,3	3065,3	3065,3	187,0	187,0	187,0	3252,3	3252,3	3252,3

REGIÃO SUL																	
Combustível	Combustível	CVU (R$/MWh)	Inflexibilidade			Ordem de Mérito			Total Mérito e INFL.			Razão Elétrica			Total UTE		
			P	M	L	P	M	L	P	M	L	P	M	L	P	M	L
PAMPA SUL (345)	Carvão	67,12				0,0	0,0	0,0	0,0	0,0	0,0				0,0	0,0	0,0
SAO SEPE (8)	Biomassa	84,44				0,0			0,0						0,0	0,0	0,0
CANDIOTA_3 (350)	Carvão	86,65															
J.LACER. C (363)	Carvão	206,84															
J.LACER. B (262)	Carvão	244,14										80,0	80,0	80,0	80,0	80,0	80,0
J.LAC. A2 (132)	Carvão	245,21										70,0	70,0	70,0	70,0	70,0	70,0
J.LAC. A1 (100)	Carvão	270,48															
URUGUAIANA (640)	Gás	278,48															
MADEIRA (4)	Biomassa	310,43	2,0	2,0	2,0				2,0	2,0	2,0				2,0	2,0	2,0
FIGUEIRA (20)	Carvão	475,68															
ARAUCARIA (484)	Gás	641,69															
CANOAS (249)	Diesel	698,14															
TOTAL SUL (2957)			2,00	2,00	2,00	0,0	0,0	0,0	2,0	2,0	2,0	150,0	150,0	150,0	152,0	152,0	152,0

O conteúdo desta publicação foi produzido pelo ONS com base em dados e informações de conhecimento público. É de responsabilidade exclusiva dos agentes e demais interessados a obtenção de outros dados e informações, a realização de análises, estudos e avaliações para fins de tomada de decisões, definição de estratégias de atuação, assunção de compromissos e obrigações e quaisquer outras finalidades, em qualquer tempo e sob qualquer condição. É proibida a reprodução ou utilização total ou parcial do presente sem a identificação da fonte.

REGIÃO NORDESTE																		
Combustível	Combustível	CVU (R$/MWh)	Inflexibilidade			Ordem de Mérito			Total Mérito e INFL.			Razão Elétrica			Total UTE		
			P	M	L	P	M	L	P	M	L	P	M	L	P	M	L
P.PECEM1 (720)	Carvão	158,02															
PROSPERIDA (28)	Gás	159,37	0,6	0,3					0,6	0,3					0,6	0,3	0,0
P.PECEM2 (365)	Carvão	168,90															
TERMOPE (533)	Gás	173,36															
FORTALEZA (327)	Gás	180,57															
PSERGIPE I (1516)	GNL	214,84															
T.BAHIA (186)	Gás	265,09	150,0	150,0	150,0				150,0	150,0	150,0				150,0	150,0	150,0
VALE ACU (368)	Gás	266,23	120,0	120,0	120,0				120,0	120,0	120,0				120,0	120,0	120,0
T.CAMACARI (120)	Gás	345,02															
TERMOCEARA (223)	Gás	371,08															
SYKUE I (30)	Biomassa	510,12															
PERNAMBU_3 (201)	Óleo	574,39															
MARACANAU (168)	Óleo	651,00															
TERMOCABO (50)	Óleo	664,88															
TERMONE (171)	Óleo	669,82															
TERMOPB (171)	Óleo	669,82															
CAMPINA_GR (169)	Óleo	672,99															
SUAPE II (381)	Óleo	679,41															
BAHIA_1 (31)	Óleo	731,03															
GLOBAL I (149)	Óleo	763,42															
GLOBAL II (149)	Óleo	763,42															
ALTOS (13)	Diesel	1024,18															
ARACATI (11)	Diesel	1024,18															
BATURITE (11)	Diesel	1024,18															
C.MAIOR (13)	Diesel	1024,18															
CAUCAIA (15)	Diesel	1024,18															
CRATO (13)	Diesel	1024,18															
IGUATU (15)	Diesel	1024,18															
JUAZEIRO N (15)	Diesel	1024,18															
MARAMBAIA (13)	Diesel	1024,18															
NAZARIA (13)	Diesel	1024,18															
PECEM (15)	Diesel	1024,18															
AREMBEPE (150)	Óleo	1167,47															
MURICY (147)	Óleo	1167,47															
POTIGUAR_3 (66)	Diesel	1223,11															
POTIGUAR (53)	Diesel	1223,12															
PETROLINA (136)	Óleo	1280,89															
PAU FERRO (94)	Diesel	1379,51															
TERMOMANAU (143)	Diesel	1379,51															
TOTAL NE (6992)			270,60	270,30	270,00	0,0	0,0	0,0	270,6	270,3	270,0	0,0	0,0	0,0	270,6	270,3	270,0

REGIÃO NORTE																	
Combustível	Combustível	CVU (R$/MWh)	Inflexibilidade			Ordem de Mérito			Total Mérito e INFL.			Razão Elétrica			Total UTE		
			P	M	L	P	M	L	P	M	L	P	M	L	P	M	L
C. ROCHA (85)	Gás	0,00	65,0	65,0	65,0				65,0	65,0	65,0				65,0	65,0	65,0
JARAQUI (75)	Gás	0,00	63,0	63,0	63,0				63,0	63,0	63,0				63,0	63,0	63,0
MANAUARA (67)	Gás	0,00	64,5	64,5	64,5				64,5	64,5	64,5				64,5	64,5	64,5
PONTA NEGR (66)	Gás	0,00	64,0	64,0	64,0				64,0	64,0	64,0				64,0	64,0	64,0
TAMBAQUI (93)	Gás	0,00	63,0	63,0	63,0				63,0	63,0	63,0				63,0	63,0	63,0
APARECIDA (166)	Gás	68,11	75,0	75,0	75,0	40,0	41,7	47,0	115,0	116,7	122,0				115,0	116,7	122,0
UTE MAUA 3 (591)	Gás	68,11	380,0	380,0	380,0	210,8	210,8	210,8	590,8	590,8	590,8				590,8	590,8	590,8
MARANHAO3 (519)	Gás	82,48	490,0	490,0	490,0	0,0	25,8		490,0	515,8	490,0				490,0	515,8	490,0
PARNAIB_IV (56)	Gás	151,69															
P. ITAQUI (360)	Carvão	163,42															
MARANHAO V (338)	Gás	165,14															
MARANHAOIV (338)	Gás	165,14															
N.VENECIA2 (270)	Gás	223,51															
GERAMAR1 (166)	Óleo	672,97															
GERAMAR2 (166)	Óleo	672,97															
TOTAL NORTE (3356)			1264,5	1264,5	1264,5	250,8	278,3	257,8	1515,3	1542,8	1522,3	0,0	0,0	0,0	1515,3	1542,8	1522,3

O conteúdo desta publicação foi produzido pelo ONS com base em dados e informações de conhecimento público. É de responsabilidade exclusiva dos agentes e demais interessados a obtenção de outros dados e informações, a realização de análises, estudos e avaliações para fins de tomada de decisões, definição de estratégias de atuação, assunção de compromissos e obrigações e quaisquer outras finalidades, em qualquer tempo e sob qualquer condição. É proibida a reprodução ou utilização total ou parcial do presente sem a identificação da fonte.