1. APRESENTAÇÃO

Na semana de 27/03 a 02/04/2021 houve chuva fraca nas bacias dos rios Jacuí, Uruguai, Iguaçu e em pontos isolados do Paranapanema, Tietê, Grande e do trecho montante a UHE Três Marias, no São Francisco. As bacias dos rios Tocantins, Xingu e Madeira apresentaram pancadas de chuva em pontos isolados.

No início da semana de 03/04 a 09/04/2021 deve ocorrer chuva fraca isolada na bacia do rio São Francisco e pancadas de chuva no Tocantins. No final da semana deve ocorrer chuva fraca nas bacias dos rios Grande, Paranaíba, no alto São Francisco e em pontos isolados do Tietê. As bacias dos rios Madeira e Xingu permanecem com a condição de pancadas de chuva em pontos isolados.

Para a semana operativa de 03/04 a 09/04/2021, houve oferta de energia da República Oriental do Uruguai e da República da Argentina. De acordo com o Art. 2º da Portaria MME nº 339, de 15 de agosto de 2018, as ofertas para importação de energia não foram consideradas na elaboração do PMO.

Os valores médios semanais do Custo Marginal de Operação – CMO dos subsistemas do SIN sofreram as seguintes alterações em relação à semana anterior:

- SE/CO: de R$ 106,11/MWh para R$ 157,67/MWh
- Sul: de R$ 106,11/MWh para R$ 157,67/MWh
- Nordeste: de R$ 0,00/MWh para R$ 140,44/MWh
- Norte: manteve-se em R$ 0,00/MWh

Desde o dia 01/01/2020, o despacho por ordem de mérito é indicado diariamente pelos resultados do modelo DESSEM. Assim, o despacho por ordem de mérito semanal, conforme publicado nesse documento, tem caráter apenas informativo. Da mesma forma, desde o dia 01/01/2021, a formação de preço deixou o formato semanal/patamar de carga e passou a ser horário, de acordo também com os resultados do modelo DESSEM.

2. NOTÍCIAS

Nos dias 29 e 30 de abril será realizada a reunião de elaboração do PMO Maio de 2021, com transmissão ao vivo através do site do ONS.

Como medida adicional de prevenção ao Coronavírus, o ONS informa que está suspensa, temporariamente, a participação presencial nas reuniões.

3. ANÁLISE DAS CONDIÇÕES HIDROMETEOROLÓGICAS

3.1. PREVISÃO PARA A PRÓXIMA SEMANA

No início da próxima semana a atuação da frente fria no litoral da Bahia e de áreas de instabilidade no interior do continente ocasionam chuva fraca isolada na bacia do rio São Francisco e pancadas de chuva no Tocantins **(Figura 1)**.

O conteúdo desta publicação foi produzido pelo ONS com base em dados e informações de conhecimento público. É de responsabilidade exclusiva dos agentes e demais interessados a obtenção de outros dados e informações, a realização de análises, estudos e avaliações para fins de tomada de decisões, definição de estratégias de atuação, assunção de compromissos e obrigações e quaisquer outras finalidades, em qualquer tempo e sob qualquer condição. É proibida a reprodução ou utilização total ou parcial do presente sem a identificação da fonte.

A atuação de novas áreas de instabilidade sobre as regiões Sudeste e Centro-Oeste no final da semana ocasiona chuva fraca nas bacias dos rios Grande, Paranaíba, no alto São Francisco e em pontos isolados do Tietê. As bacias dos rios Madeira e Xingu permanecem com a condição de pancadas de chuva em pontos isolados.

Figura 1- Precipitação acumulada prevista pelo modelo ECMWF (ECMWF) para o período de 03/04/2021 a 09/04/2021.

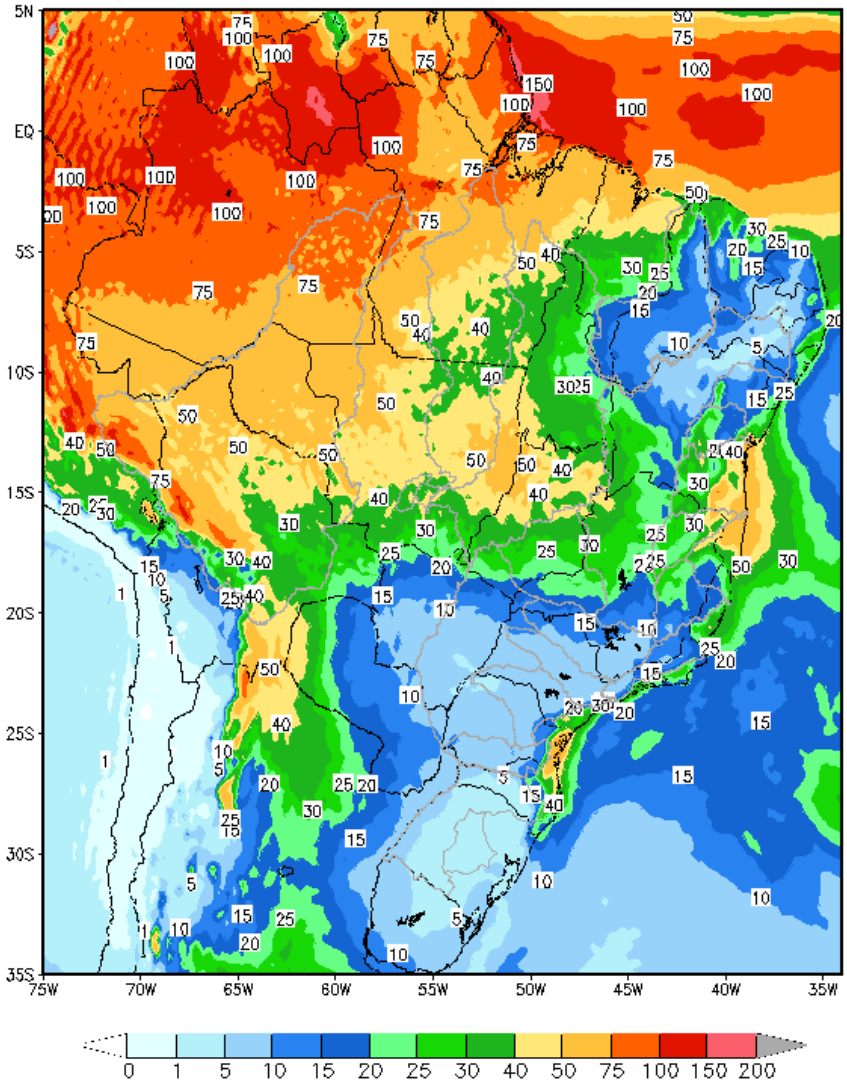

Em comparação com os valores estimados para a semana em curso, prevê-se para a próxima semana operativa recessão nas afluências de todos os subsistemas. A previsão mensal para abril indica a ocorrência de afluências abaixo da média histórica para todos os subsistemas, se aproximando mais da média histórica no subsistema Norte.

O conteúdo desta publicação foi produzido pelo ONS com base em dados e informações de conhecimento público. É de responsabilidade exclusiva dos agentes e demais interessados a obtenção de outros dados e informações, a realização de análises, estudos e avaliações para fins de tomada de decisões, definição de estratégias de atuação, assunção de compromissos e obrigações e quaisquer outras finalidades, em qualquer tempo e sob qualquer condição. É proibida a reprodução ou utilização total ou parcial do presente sem a identificação da fonte.

Tabela 1 – Previsão de ENAs da Revisão 1 de Abril/2021

Revisão 1 do PMO de Abril/2021 - ENAs previstas				
Subsistema	03/04 a 09/04/2021		Mês de abril	
	MWmed	%MLT	MWmed	%MLT
SE/CO	37.298	68	36.391	66
S	2.959	45	3.481	53
NE	4.529	39	3.942	34
N	26.245	97	25.428	94

4. PREVISÃO DE CARGA

As previsões de carga consolidadas para o mês de abril/2021 consideram a manutenção do desempenho industrial, ainda que em níveis inferiores ao observado no ano de 2020. Associado a isso, devido ao recrudescimento da pandemia, o comportamento da carga deverá ser impactado de forma negativa, nas primeiras semanas operativas do mês em função da intensificação das medidas restritivas em parte do país.

Para a próxima semana operativa as sinalizações meteorológicas indicam a ocorrências de temperaturas médias inferiores as observadas na semana em curso para as capitais do subsistema Sudeste/Centro-Oeste e Sul. As capitais dos subsistemas Nordeste e Norte, seguem com expectativa de manutenção de temperaturas elevadas, típicas para essa época do ano. Destaca-se a expectativa de atuação de uma frente fria em Salvador o que acarretará chuva fraca ao longo do período.

As taxas de crescimento previstas para o mês de abril em relação ao mesmo mês do ano anterior, são de 15,9% no subsistema Sudeste/Centro-Oeste, 16,5% para o subsistema Sul, 12,9% no Nordeste e 16,2% no subsistema do Norte. Ressalta-se que as expressivas taxas de crescimento previstas estão influenciadas pelas reduções de carga observadas em abril/2020 devido as medidas de isolamento social implementadas no país para conter o avanço da pandemia.

Tabela 2 – Evolução da carga do PMO de Abril/2021

Subsistema	CARGA SEMANAL (MWmed)					CARGA MENSAL (MWmed)	
	1ª Sem	2ª Sem	3ª Sem	4ª Sem	5ª Sem	abr/21	Var. (%) abr/21 -> abr/20
SE/CO	40.996	40.997	41.237	40.818	40.823	40.971	15,9%
Sul	11.511	12.128	12.488	12.097	11.942	12.120	16,5%
Nordeste	11.223	11.338	11.237	11.065	11.163	11.202	12,9%
Norte	5.831	5.872	5.808	5.774	5.821	5.820	16,2%
SIN	69.561	70.335	70.771	69.754	69.748	70.113	15,5%

O conteúdo desta publicação foi produzido pelo ONS com base em dados e informações de conhecimento público. É de responsabilidade exclusiva dos agentes e demais interessados a obtenção de outros dados e informações, a realização de análises, estudos e avaliações para fins de tomada de decisões, definição de estratégias de atuação, assunção de compromissos e obrigações e quaisquer outras finalidades, em qualquer tempo e sob qualquer condição. É proibida a reprodução ou utilização total ou parcial do presente sem a identificação da fonte.

5. PRINCIPAIS RESULTADOS

5.1. CUSTO MARGINAL DE OPERAÇÃO (CMO)

A tabela a seguir apresenta o CMO, por subsistema e patamar de carga para próxima semana operativa.

Tabela 3 – CMO por patamar de carga

Patamares de Carga	CMO (R$/MWh)			
	SE/CO	S	NE	N
Pesada	165,53	165,53	141,22	0,00
Média	164,28	164,28	141,22	0,00
Leve	149,62	149,62	139,59	0,00
Média Semanal	157,67	157,67	140,44	0,00

Na figura a seguir é apresentada a evolução do CMO médio semanal ao longo deste PMO.

Figura 2 – Evolução semanal do CMO

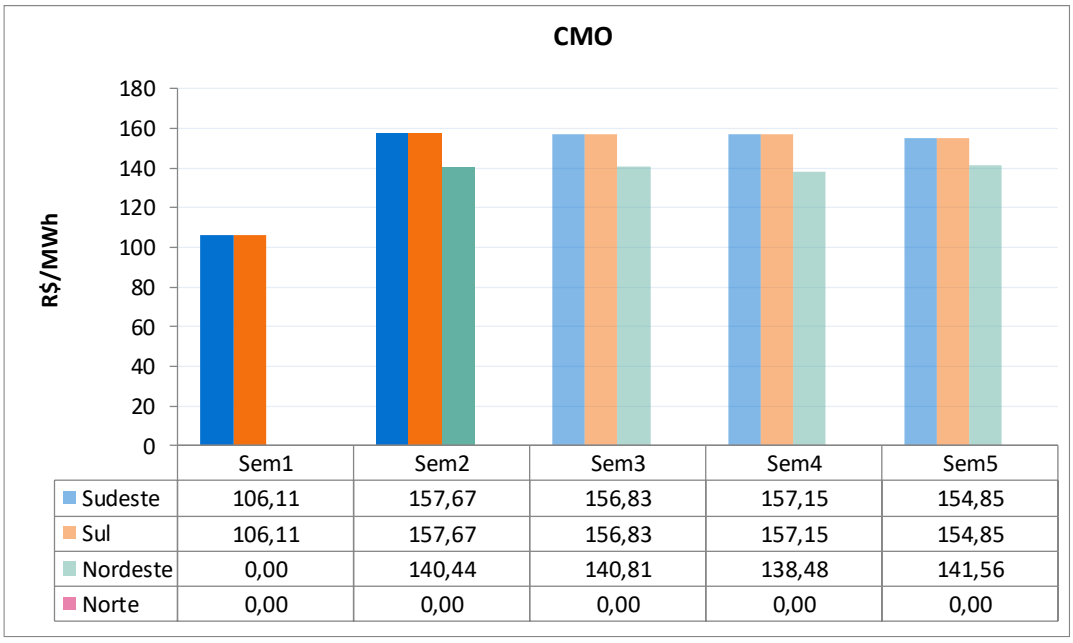

5.2. POLÍTICA DE OPERAÇÃO ENERGÉTICA

Para esta semana operativa, está prevista a seguinte política de intercâmbio de energia entre regiões:

Região SE/CO → Geração dimensionada para fechamento do balanço energético do SIN.

Região Sul → Geração hidráulica modulando em função dos recursos energéticos da região, com a exploração do intercâmbio de energia sempre que necessário, respeitando-se os limites elétricos vigentes.

Região NE → Redução da geração hidráulica e eólica e da exportação de energia, modulando em função dos recursos energéticos da região, respeitando-se os limites elétricos vigentes.

Região Norte → Continuidade da exploração das disponibilidades energéticas, respeitando-se os limites elétricos vigentes.

O conteúdo desta publicação foi produzido pelo ONS com base em dados e informações de conhecimento público. É de responsabilidade exclusiva dos agentes e demais interessados a obtenção de outros dados e informações, a realização de análises, estudos e avaliações para fins de tomada de decisões, definição de estratégias de atuação, assunção de compromissos e obrigações e quaisquer outras finalidades, em qualquer tempo e sob qualquer condição. É proibida a reprodução ou utilização total ou parcial do presente sem a identificação da fonte.

6. ANÁLISE DA VARIAÇÃO SEMANAL DO CMO

Esta análise visa identificar os principais parâmetros cujas atualizações impactaram os CMO deste PMO, em comparação com os valores obtidos na última revisão.

Foram realizados 8 estudos, onde o caso inicial foi construído com base nos dados oficiais da última revisão deste PMO. Neste primeiro estudo, denominado de "previsão perfeita", a partida dos reservatórios foi estimada conforme indicado para esta semana na última revisão.

O segundo estudo foi realizado com os dados do caso inicial sendo substituída a previsão de vazões.

A partir do conjunto de dados do segundo estudo foram elaborados os demais casos em que foram atualizados, sequencialmente, as seguintes informações: níveis de partida dos reservatórios, previsão de carga, disponibilidade das usinas térmicas e hidráulicas, restrições de limites de intercâmbio, restrições hidráulicas e, por fim, os demais dados que compõem toda informação referente a atual revisão.

O principal fator que influenciou na elevação do CMO nos subsistemas Sudeste/Centro Oeste e Sul, em relação à semana anterior, foi a atualização da previsão de vazões.

Para o subsistema Nordeste já era prevista a elevação do CMO para essa semana, como pode ser observado no resultado do primeiro estudo de sensibilidade. Esta tendência foi acentuada, principalmente, em função da atualização da previsão de vazões.

Para o subsistema Norte o CMO manteve-se nulo e sem variações em relação à semana anterior, devido a seu excedente de geração hidráulica e ao atingimento dos limites máximos de exportação de energia.

Os custos marginais de operação dos subsistemas Sudeste/Centro-Oeste e Sul estão acoplados e apresentados na figura a seguir.

Figura 3 – Análise da variação do CMO nos subsistemas SE/CO e Sul

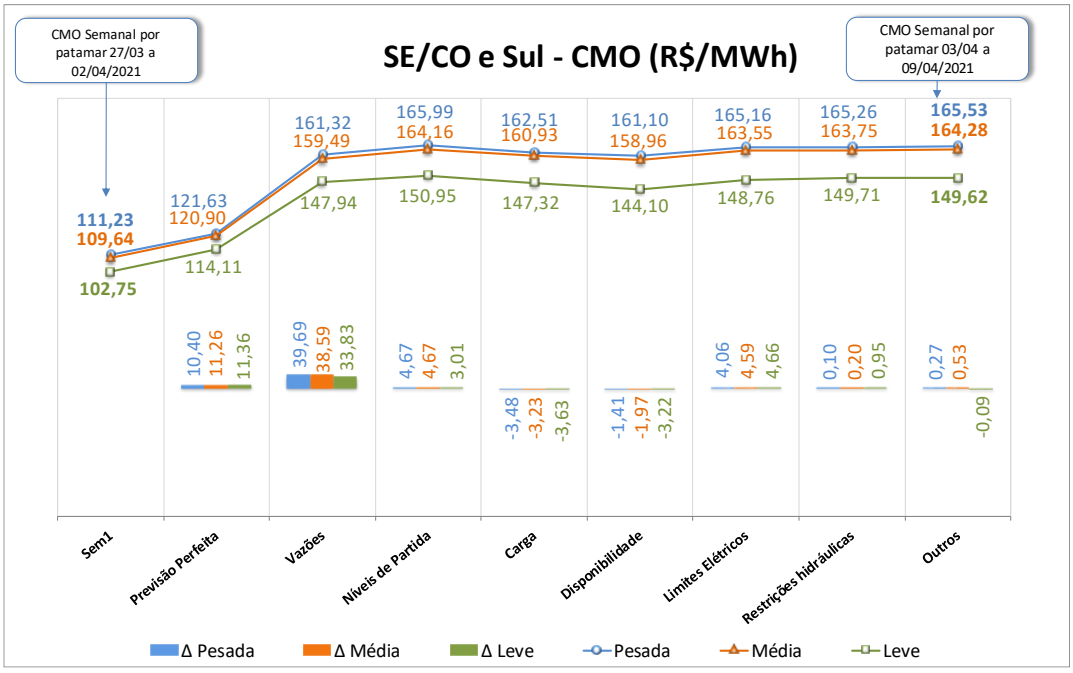

O conteúdo desta publicação foi produzido pelo ONS com base em dados e informações de conhecimento público. É de responsabilidade exclusiva dos agentes e demais interessados a obtenção de outros dados e informações, a realização de análises, estudos e avaliações para fins de tomada de decisões, definição de estratégias de atuação, assunção de compromissos e obrigações e quaisquer outras finalidades, em qualquer tempo e sob qualquer condição. É proibida a reprodução ou utilização total ou parcial do presente sem a identificação da fonte.

Para o subsistema Nordeste, a variação do CMO pode ser vista na figura abaixo.

Figura 4 – Análise da variação do CMO no subsistema Nordeste

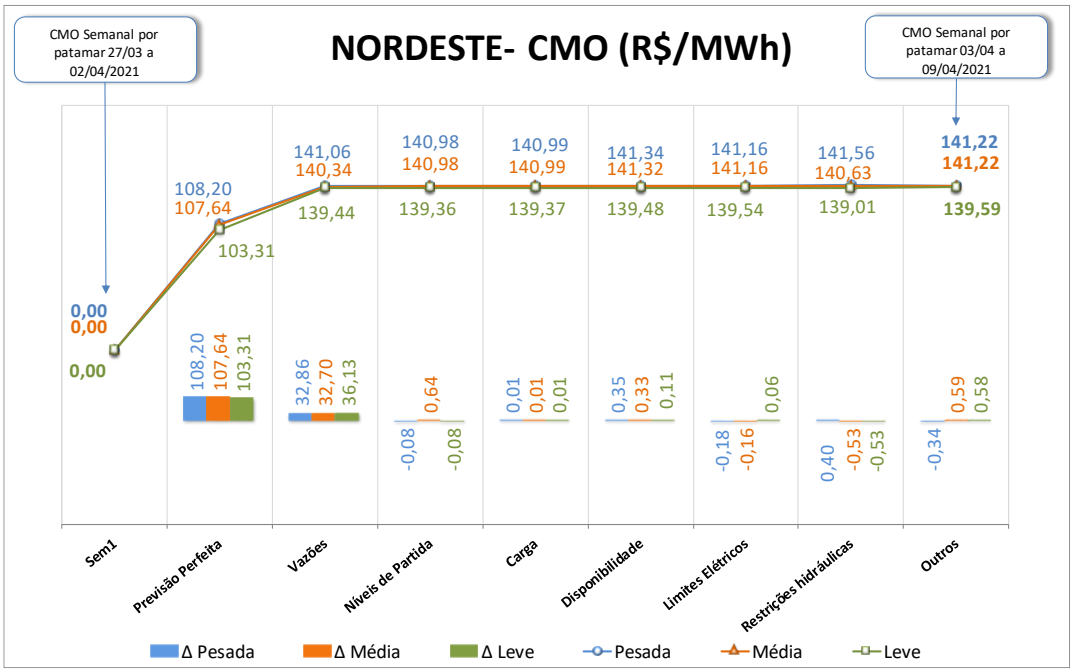

O conteúdo desta publicação foi produzido pelo ONS com base em dados e informações de conhecimento público. É de responsabilidade exclusiva dos agentes e demais interessados a obtenção de outros dados e informações, a realização de análises, estudos e avaliações para fins de tomada de decisões, definição de estratégias de atuação, assunção de compromissos e obrigações e quaisquer outras finalidades, em qualquer tempo e sob qualquer condição. É proibida a reprodução ou utilização total ou parcial do presente sem a identificação da fonte.

7. GERAÇÃO TÉRMICA

A Figura 5 apresenta, para cada subsistema, o despacho térmico por modalidade, para a próxima semana operativa.

Figura 5 – Geração térmica para a próxima semana operativa

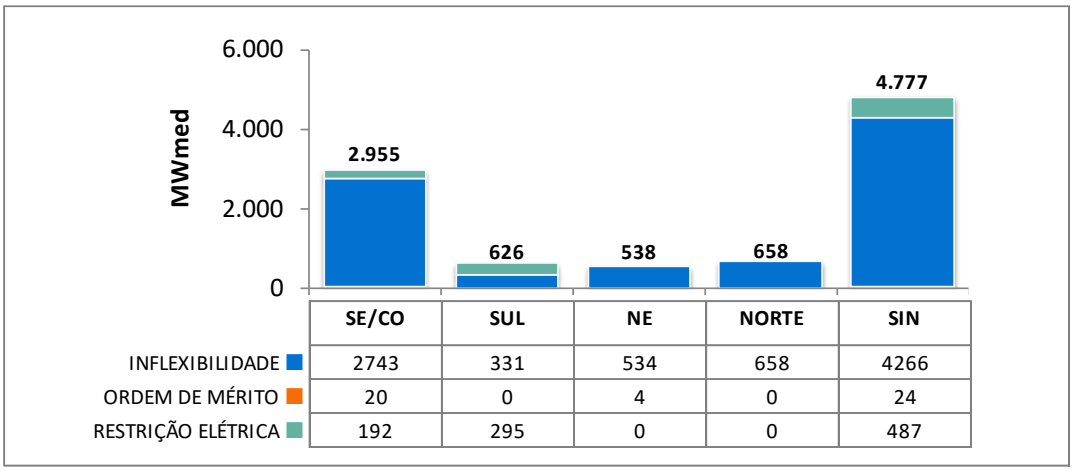

	SE/CO	SUL	NE	NORTE	SIN
INFLEXIBILIDADE	2743	331	534	658	4266
ORDEM DE MÉRITO	20	0	4	0	24
RESTRIÇÃO ELÉTRICA	192	295	0	0	487

Na tabela abaixo segue a Indicação de despacho antecipado por ordem de mérito de custo para a semana de 05/06/2021 a 11/06/2021.

Tabela 4 – UTEs com contrato de combustível GNL

UTE			Benefício (R$/MWh)		
Nome	Cod	CVU (R$/MWh)	Carga Pesada	Carga Média	Carga Leve
SANTA CRUZ	86	195,33	207,18 (1)	207,18 (1)	206,34 (1)
LUIZORMELO	15	296,89	207,18 (2)	207,18 (2)	206,34 (2)
PSERGIPE I	224	284,40	141,93 (2)	141,93 (2)	141,92 (2)

(1) Comandado o despacho antecipado por ordem de mérito de custo nesse patamar

(2) NÃO foi comandado o despacho antecipado por ordem de mérito de custo nesse patamar

Assim sendo, há previsão de despacho antecipado por ordem de mérito de custo apenas para a UTE Santa Cruz, para a semana de 05/06 a 11/06/2021.

Apesar da UTE Luiz O. R. Melo não estar despachada por ordem de mérito, há necessidade do despacho de, pelo menos, 204 MW dessa usina para reduzir o risco de corte de carga na região de Governador Valadares e na região Norte do Espírito Santo. Desta forma, a UTE Luiz O. R. Melo deverá ser despachada por razão elétrica, na referida semana, em 204 MW.

O conteúdo desta publicação foi produzido pelo ONS com base em dados e informações de conhecimento público. É de responsabilidade exclusiva dos agentes e demais interessados a obtenção de outros dados e informações, a realização de análises, estudos e avaliações para fins de tomada de decisões, definição de estratégias de atuação, assunção de compromissos e obrigações e quaisquer outras finalidades, em qualquer tempo e sob qualquer condição. É proibida a reprodução ou utilização total ou parcial do presente sem a identificação da fonte.

8. IMPORTAÇÃO DE ENERGIA DA REPÚBLICA ORIENTAL DO URUGUAI

8.1. República Oriental do Uruguai

Para a próxima semana operativa, foram declaradas as seguintes ofertas de importação de energia da República Oriental do Uruguai para o Sistema Interligado Nacional - SIN através das conversoras de Rivera (70 MW) e Melo (500 MW).

- **Eletrobras**

Tabela 5 – Energia ofertada para importação

	Oferta de Energia para a Semana de 03/04 a 09/04 (MWmed)				
	Bloco 1	Bloco 2	Bloco 3	Bloco 4	Total
Carga Pesada	70	25	90	135	320
Carga Média	70	25	90	135	320
Carga Leve	70	25	90	135	320
CVU (R$/MWh)	1.121,01	1.234,37	1.331,70	1.434,75	

- **Enel**

Conforme declaração do agente, esta importação poderá ser realizada exclusivamente pela conversora Melo.

Tabela 6 – Energia ofertada para importação

	Oferta de Energia para a Semana de 03/04 a 09/04 (MWmed)			
	Bloco 1	Bloco 2	Bloco 3	Total
Carga Pesada	25	90	135	250
Carga Média	25	90	135	250
Carga Leve	25	90	135	250
CVU (R$/MWh)	1.239,95	1.341,21	1.446,00	

O conteúdo desta publicação foi produzido pelo ONS com base em dados e informações de conhecimento público. É de responsabilidade exclusiva dos agentes e demais interessados a obtenção de outros dados e informações, a realização de análises, estudos e avaliações para fins de tomada de decisões, definição de estratégias de atuação, assunção de compromissos e obrigações e quaisquer outras finalidades, em qualquer tempo e sob qualquer condição. É proibida a reprodução ou utilização total ou parcial do presente sem a identificação da fonte.

8.2. República da Argentina

- **Enel**

Para a próxima semana operativa, foi declarada a seguinte oferta de importação de energia da República da Argentina para o SIN através das conversoras de Garabi 1 (1.100 MW) e Garabi 2 (1.100 MW).

Tabela 7 – Energia ofertada para importação

	Oferta de Energia para a Semana de 03/04 a 09/04 (MWmed)						
	Bloco 1	Bloco 2	Bloco 3	Bloco 4	Bloco 5	Bloco 6	Total
Carga Pesada	300	300	300	400	400	500	2.200
Carga Média	300	300	300	400	400	500	2.200
Carga Leve	300	300	300	400	400	500	2.200
CVU (R$/MWh)	638,50	673,62	708,75	1.305,29	1.516,03	1.656,18	

Nota: Detalhes sobre a importação de energia vide Portaria Nº 339, de 15 de agosto de 2018 disponível em: http://pesquisa.in.gov.br/imprensa/jsp/visualiza/index.jsp?data=17/08/2018&jornal=515&pagina=60&totalArquivos=136

9. ESTIMATIVA DE ENCARGOS OPERATIVOS

A tabela a seguir apresenta a expectativa do custo de despacho térmico por restrição elétrica para esta semana operativa.

Tabela 8 – Expectativa de custo de despacho térmico por Restrição Elétrica

UTE Potência Instalada (MW)	CVU (R$/MWh)	Geração (MWmed)			ESS ELÉTRICO
		Carga Pesada	Carga Média	Carga Leve	
LUIZORMELO (204)	R$ 296,89	192,0	192,0	192,0	**R$ 4.490.645,81**
TOTAL SE/CO					R$ 4.490.645,81

O conteúdo desta publicação foi produzido pelo ONS com base em dados e informações de conhecimento público. É de responsabilidade exclusiva dos agentes e demais interessados a obtenção de outros dados e informações, a realização de análises, estudos e avaliações para fins de tomada de decisões, definição de estratégias de atuação, assunção de compromissos e obrigações e quaisquer outras finalidades, em qualquer tempo e sob qualquer condição. É proibida a reprodução ou utilização total ou parcial do presente sem a identificação da fonte.

10. ARMAZENAMENTOS OPERATIVOS

Para uma melhor avaliação de diversos cenários hidrometeorológicos, notadamente, aqueles de curto prazo e suas influências nas previsões de vazões nos subsistemas, os resultados desta revisão do PMO contemplam cenários de afluências visando melhor representar a ocorrência de precipitação e, consequentemente, seus efeitos sobre as afluências e armazenamentos.

Além dos resultados associados ao valor esperado das previsões de afluências, as simulações operativas também foram realizadas com os limites superior e inferior das previsões de afluências. Apresentamos a seguir os resultados obtidos com a aplicação dos diferentes cenários de afluência.

Tabela 9 – Previsão de ENA dos cenários de sensibilidade

Subsistema	ENERGIAS NATURAIS AFLUENTES					
	Previsão Mensal					
	LI		VE		LS	
	(MWmed)	%MLT	(MWmed)	%MLT	(MWmed)	%MLT
SE/CO	31.567	**58**	36.391	**66**	41.209	**75**
Sul	1.874	**28**	3.481	**53**	5.439	**82**
Nordeste	3.201	**28**	3.942	**34**	4.679	**41**
Norte	22.807	**84**	25.428	**94**	27.882	**103**

Tabela 10 – Previsão de %EARmáx para o final do mês

Subsistema	% EARmáx 02/04	% EARmáx - 30/04		
	NÍVEL INICIAL	NÍVEL PMO		
	VE	LI	VE	LS
SE/CO	35,4	34,3	36,0	37,6
Sul	61,3	55,2	61,3	69,4
Nordeste	68,5	65,3	66,9	68,5
Norte	78,1	82,3	83,0	83,6

O conteúdo desta publicação foi produzido pelo ONS com base em dados e informações de conhecimento público. É de responsabilidade exclusiva dos agentes e demais interessados a obtenção de outros dados e informações, a realização de análises, estudos e avaliações para fins de tomada de decisões, definição de estratégias de atuação, assunção de compromissos e obrigações e quaisquer outras finalidades, em qualquer tempo e sob qualquer condição. É proibida a reprodução ou utilização total ou parcial do presente sem a identificação da fonte.

11. RESERVATÓRIOS EQUIVALENTES DE ENERGIA

A seguir são apresentadas as previsões de Energia Natural Afluente para a próxima semana operativa e para o mês de abril, bem como as previsões de Energia Armazenada nos Reservatórios Equivalentes de Energia – REE, desta revisão do PMO.

Tabela 11 – Previsão de ENA por REE

Valor Esperado das Energias Naturais Afluentes				
REE	Previsão Semanal		Previsão Mensal	
	03/04/2021 a 09/04/2021		abr/21	
	(MWmed)	%MLT	(MWmed)	%MLT
Sudeste	4.511	62	4.313	59
Madeira	9.987	86	9.519	82
Teles Pires	4.155	130	3.819	120
Itaipu	2.856	80	2.916	82
Paraná	12.192	46	12.286	46
Paranapanema	1.257	53	1.304	55
Sul	1.157	36	1.483	46
Iguaçu	1.802	54	1.998	60
Nordeste	4.529	39	3.942	34
Norte	11.252	77	11.087	76
Belo Monte	12.220	113	12.108	111
Manaus	2.092	133	2.160	138

Tabela 12 – Previsão de %EARmáx por REE

% Energia Armazenável Máxima		
REE	Previsão Semanal	Previsão Mensal
	09/abr	30/abr
	(%EARmáx)	(%EARmáx)
Sudeste	41,3	42,7
Madeira	99,3	94,0
Teles Pires	92,9	100,0
Itaipu	32,5	-
Paraná	32,7	32,5
Paranapanema	41,6	44,1
Sul	46,2	43,7
Iguaçu	73,6	77,2
Nordeste	68,2	66,9
Norte	82,8	84,5
Belo Monte	100,0	34,0
Manaus	42,4	60,2

O conteúdo desta publicação foi produzido pelo ONS com base em dados e informações de conhecimento público. É de responsabilidade exclusiva dos agentes e demais interessados a obtenção de outros dados e informações, a realização de análises, estudos e avaliações para fins de tomada de decisões, definição de estratégias de atuação, assunção de compromissos e obrigações e quaisquer outras finalidades, em qualquer tempo e sob qualquer condição. É proibida a reprodução ou utilização total ou parcial do presente sem a identificação da fonte.

12. DESPACHO TÉRMICO POR MODALIDADE, PATAMAR DE CARGA E USINA

Nas tabelas abaixo, a diferenciação entre geração por inflexibilidade e por ordem de mérito tem caráter informativo, com o objetivo de detalhar a informação de inflexibilidade enviada pelos respectivos agentes para esta revisão do PMO. Ressalta-se que nas etapas de Programação Diária e Tempo Real, o montante despachado nas usinas termelétricas indicadas por ordem de mérito é plenamente intitulado como ordem de mérito.

REGIÃO SUDESTE/CENTRO-OESTE

Térmicas Potência (MW)	Combustível	CVU (R$/MWh)	Inflexibilidade			Ordem de Mérito			Total Mérito e INFL.			Razão Elétrica			Total UTE		
			P	M	L	P	M	L	P	M	L	P	M	L	P	M	L
ATLAN_CSA (255)	Resíduos	0,00	164,0	164,0	164,0				164,0	164,0	164,0				164,0	164,0	164,0
ANGRA 2 (1350)	Nuclear	20,12	1220,0	1220,0	1220,0	0,0	0,0	0,0	1220,0	1220,0	1220,0				1220,0	1220,0	1220,0
ANGRA 1 (640)	Nuclear	31,17	640,0	640,0	640,0	0,0	0,0	0,0	640,0	640,0	640,0				640,0	640,0	640,0
NORTEFLU 1 (400)	Gás	85,23	400,0	400,0	400,0	0,0	0,0	0,0	400,0	400,0	400,0				400,0	400,0	400,0
NORTEFLU 2 (100)	Gás	98,99	100,0	100,0	100,0	0,0	0,0	0,0	100,0	100,0	100,0				100,0	100,0	100,0
UTE STA VI (41)	Biomassa	121,49				20,0	20,0	20,0	20,0	20,0	20,0				20,0	20,0	20,0
NORTEFLU 3 (200)	Gás	187,93															
BAIXADA FL (530)	Gás	192,30															
SANTA CRUZ (500)	GNL	195,33															
ATLANTICO (235)	Resíduos	195,80	218,7	218,7	218,7				218,7	218,7	218,7				218,7	218,7	218,7
T.LAGOAS (350)	Gás	261,44															
JUIZ DE FO (87)	Gás	283,74															
LUIZORMELO (204)	GNL	296,89										192,0	192,0	192,0	192,0	192,0	192,0
ST.CRUZ 34 (436)	Óleo	310,41															
TERMORIO (1036)	Gás	327,82															
CUBATAO (216)	Gás	338,77															
SEROPEDICA (386)	Gás	408,99															
IBIRITE (226)	Gás	411,45															
PIRAT.12 O (200)	Gás	470,34															
CUIABA CC (529)	Gás	543,82															
NORTEFLU 4 (127)	Gás	546,47															
NPIRATINGA (572)	Gás	548,04															
T.MACAE (929)	Gás	736,13															
PALMEIR_GO (176)	Diesel	761,51															
VIANA (175)	Óleo	905,13															
TNORTE 2 (340)	Óleo	910,86															
CAMPOS (25)	Gás	978,10															
DAIA (44)	Diesel	1017,64															
GOIANIA 2 (140)	Diesel	1064,13															
XAVANTES (54)	Diesel	1462,46															
TOTAL SE/CO (10503)			2742,7	2742,7	2742,7	20,0	20,0	20,0	2762,7	2762,7	2762,7	192,0	192,0	192,0	2954,7	2954,7	2954,7

REGIÃO SUL

Térmicas Potência (MW)	Combustível	CVU (R$/MWh)	Inflexibilidade			Ordem de Mérito			Total Mérito e INFL.			Razão Elétrica			Total UTE		
			P	M	L	P	M	L	P	M	L	P	M	L	P	M	L
PAMPA SUL (345)	Carvão	69,75				0,0	0,0	0,0	0,0	0,0	0,0				0,0	0,0	0,0
SAO SEPE (8)	Biomassa	87,75	4,0	4,0	4,0	0,0	0,0	0,0	4,0	4,0	4,0				4,0	4,0	4,0
CANDIOTA_3 (350)	Carvão	87,78	325,0	325,0	325,0	0,0	0,0	0,0	325,0	325,0	325,0				325,0	325,0	325,0
J.LACER. C (363)	Carvão	206,84										180,0	180,0	180,0	180,0	180,0	180,0
J.LACER. B (262)	Carvão	244,14										80,0	80,0	80,0	80,0	80,0	80,0
J.LAC. A2 (132)	Carvão	245,21										35,0	35,0	35,0	35,0	35,0	35,0
J.LAC. A1 (100)	Carvão	270,48															
MADEIRA (4)	Biomassa	314,98	2,0	2,0	2,0				2,0	2,0	2,0				2,0	2,0	2,0
FIGUEIRA (20)	Carvão	475,68															
URUGUAIANA (640)	Gás	606,28															
ARAUCARIA (484)	Gás	652,60															
CANOAS (249)	Diesel	698,14															
TOTAL SUL (2957)			331,0	331,0	331,0	0,0	0,0	0,0	331,0	331,0	331,0	295,0	295,0	295,0	626,0	626,0	626,0

O conteúdo desta publicação foi produzido pelo ONS com base em dados e informações de conhecimento público. É de responsabilidade exclusiva dos agentes e demais interessados a obtenção de outros dados e informações, a realização de análises, estudos e avaliações para fins de tomada de decisões, definição de estratégias de atuação, assunção de compromissos e obrigações e quaisquer outras finalidades, em qualquer tempo e sob qualquer condição. É proibida a reprodução ou utilização total ou parcial do presente sem a identificação da fonte.

REGIÃO NORDESTE

Térmicas Potência (MW)	Combustível	CVU (R$/MWh)	Inflexibilidade			Ordem de Mérito			Total Mérito e INFL.			Razão Elétrica			Total UTE		
			P	M	L	P	M	L	P	M	L	P	M	L	P	M	L
ERB CANDEI (17)	Biomassa	87,81	0,0	0,9	2,3	2,6	3,5	5,5	2,6	4,4	7,8				2,6	4,4	7,8
TERMOPE (533)	Gás	165,28	532,7	532,7	532,7				532,7	532,7	532,7				532,7	532,7	532,7
PROSPERIDA (28)	Gás	165,61															
P.PECEM1 (720)	Carvão	210,01															
P.PECEM2 (365)	Carvão	218,88															
FORTALEZA (327)	Gás	223,72															
PSERGIPE I (1516)	GNL	284,40															
TERMOCEARA (223)	Gás	428,47															
VALE ACU (368)	Gás	453,90															
T.BAHIA (186)	Gás	461,03															
SYKUE I (30)	Biomassa	510,12															
PERNAMBU_3 (201)	Óleo	779,70															
BAHIA_1 (31)	Óleo	816,03															
MARACANAU (168)	Óleo	879,98															
ALTOS (13)	Diesel	881,41															
ARACATI (11)	Diesel	881,41															
BATURITE (11)	Diesel	881,41															
C.MAIOR (13)	Diesel	881,41															
CAUCAIA (15)	Diesel	881,41															
CRATO (13)	Diesel	881,41															
IGUATU (15)	Diesel	881,41															
JUAZEIRO N (15)	Diesel	881,41															
MARAMBAIA (13)	Diesel	881,41															
NAZARIA (13)	Diesel	881,41															
PECEM (15)	Diesel	881,41															
TERMOCABO (50)	Óleo	894,05															
TERMONE (171)	Óleo	897,67															
TERMOPB (171)	Óleo	897,67															
CAMPINA_GR (169)	Óleo	905,15															
SUAPE II (381)	Óleo	924,42															
POTIGUAR_3 (66)	Diesel	1001,38															
POTIGUAR (53)	Diesel	1001,39															
AREMBEPE (150)	Óleo	1019,77															
MURICY (147)	Óleo	1019,77															
GLOBAL I (149)	Óleo	1025,63															
GLOBAL II (149)	Óleo	1025,63															
PETROLINA (136)	Óleo	1118,83															
PAU FERRO (94)	Diesel	1133,69															
TERMOMANAU (143)	Diesel	1133,69															
TOTAL NE (6889)			532,7	533,6	535,0	2,6	3,5	5,5	535,3	537,1	540,5	0,0	0,0	0,0	535,3	537,1	540,5

REGIÃO NORTE

Térmicas Potência (MW)	Combustível	CVU (R$/MWh)	Inflexibilidade			Ordem de Mérito			Total Mérito e INFL.			Razão Elétrica			Total UTE		
			P	M	L	P	M	L	P	M	L	P	M	L	P	M	L
C. ROCHA (85)	Gás	0,00	65,0	65,0	65,0				65,0	65,0	65,0				65,0	65,0	65,0
JARAQUI (75)	Gás	0,00	63,0	63,0	63,0				63,0	63,0	63,0				63,0	63,0	63,0
MANAUARA (67)	Gás	0,00	64,5	64,5	64,5				64,5	64,5	64,5				64,5	64,5	64,5
PONTA NEGR (66)	Gás	0,00	64,0	64,0	64,0				64,0	64,0	64,0				64,0	64,0	64,0
TAMBAQUI (93)	Gás	0,00	63,0	63,0	63,0				63,0	63,0	63,0				63,0	63,0	63,0
MARANHAO3 (519)	Gás	85,72															
APARECIDA (166)	Gás	94,62	75,0	75,0	75,0				75,0	75,0	75,0				75,0	75,0	75,0
UTE MAUA 3 (591)	Gás	94,62	264,0	264,0	264,0				264,0	264,0	264,0				264,0	264,0	264,0
PARNAIB_IV (56)	Gás	151,69															
MARAN_VL_7 (336)	Gás	180,42															
MARAN_VL22 (1)	Gás	180,42															
MARANIVL_7 (336)	Gás	180,42															
MARANIVL22 (1)	Gás	180,42															
P. ITAQUI (360)	Carvão	212,97															
N.VEN2_L22 (27)	Gás	232,01															
N.VEN2_L7 (151)	Gás	232,27															
GERAMAR1 (166)	Óleo	905,11															
GERAMAR2 (166)	Óleo	905,11															
TOTAL NORTE (3264)			658,5	658,5	658,5	0,0	0,0	0,0	658,5	658,5	658,5	0,0	0,0	0,0	658,5	658,5	658,5

O conteúdo desta publicação foi produzido pelo ONS com base em dados e informações de conhecimento público. É de responsabilidade exclusiva dos agentes e demais interessados a obtenção de outros dados e informações, a realização de análises, estudos e avaliações para fins de tomada de decisões, definição de estratégias de atuação, assunção de compromissos e obrigações e quaisquer outras finalidades, em qualquer tempo e sob qualquer condição. É proibida a reprodução ou utilização total ou parcial do presente sem a identificação da fonte.