1. APRESENTAÇÃO

No mês de julho foram observados totais elevados de precipitação nas bacias dos rios Jacuí e Uruguai, principalmente na primeira quinzena do referido mês. Com essa configuração as bacias dos rios Jacuí e Uruguai apresentam anomalia positiva de chuva. Na última semana operativa de julho, houve chuva fraca nas bacias dos rios Jacuí, Uruguai e em pontos isolados das cabeceiras dos rios Iguaçu e Paranapanema.

Na semana operativa de 01/08 a 07/08/2020 não há previsão de precipitações nas bacias hidrográficas de interesse do Sistema Interligado Nacional – SIN.

Para a semana operativa de 01/08 a 07/08/2020, houve oferta de energia da República Oriental do Uruguai. De acordo com o Art. 2º da Portaria MME nº 339, de 15 de agosto de 2018, as ofertas para importação de energia não foram consideradas na elaboração do PMO. Para a referida semana, não houve oferta de energia da República da Argentina.

Os valores médios semanais do Custo Marginal de Operação – CMO dos subsistemas do SIN sofreram as seguintes alterações em relação à semana anterior:

- SE/CO: de R$ 91,42/MWh para R$ 90,75/MWh
- Sul: de R$ 91,42/MWh para R$ 90,75/MWh
- Nordeste: de R$ 73,92/MWh para R$ 64,37/MWh
- Norte: de R$ 91,42/MWh para R$ 88,94/MWh

Desde o dia 01/01/2020, o despacho por ordem de mérito é indicado diariamente pelos resultados do modelo DESSEM. Assim, o despacho por ordem de mérito semanal, conforme publicado nesse documento, tem caráter apenas informativo.

2. NOTÍCIAS

Nos dias 27 e 28 de agosto será realizada a reunião de elaboração do PMO Setembro de 2020, com transmissão ao vivo através do site do ONS.

Como medida adicional de prevenção ao Coronavírus, o ONS informa que está suspensa, temporariamente, a participação presencial nas reuniões.

3. INFORMAÇÕES PARA ESTUDOS ENERGÉTICOS DE MÉDIO PRAZO - CONSTRUÇÃO DA FUNÇÃO DE CUSTO FUTURO

A atualização de dados para os estudos energéticos de médio prazo é realizada mensalmente quando da elaboração do PMO, tendo por base as informações fornecidas pela ANEEL, MME, EPE, CCEE e Agentes, além de diversas áreas do ONS.

O conteúdo desta publicação foi produzido pelo ONS com base em dados e informações de conhecimento público. É de responsabilidade exclusiva dos agentes e demais interessados a obtenção de outros dados e informações, a realização de análises, estudos e avaliações para fins de tomada de decisões, definição de estratégias de atuação, assunção de compromissos e obrigações e quaisquer outras finalidades, em qualquer tempo e sob qualquer condição. É proibida a reprodução ou utilização total ou parcial do presente sem a identificação da fonte.

3.1. ATUALIZAÇÃO DAS INFORMAÇÕES ESTRUTURAIS

3.1.1. Oferta

Nas **Figura 1**, **Figura 2** e **Figura 3**, a seguir, são apresentadas as evoluções da oferta hidroelétrica, termoelétrica e da disponibilidade das usinas não simuladas individualmente, respectivamente, em comparação ao PMO de julho/2020, identificando eventuais atrasos ou antecipações de cronograma feitos na reunião de acompanhamento do Departamento de Monitoramento do Setor Elétrico – DMSE/MME, realizada em 23/07/2020.

Figura 1 - Evolução da potência instalada das UHEs

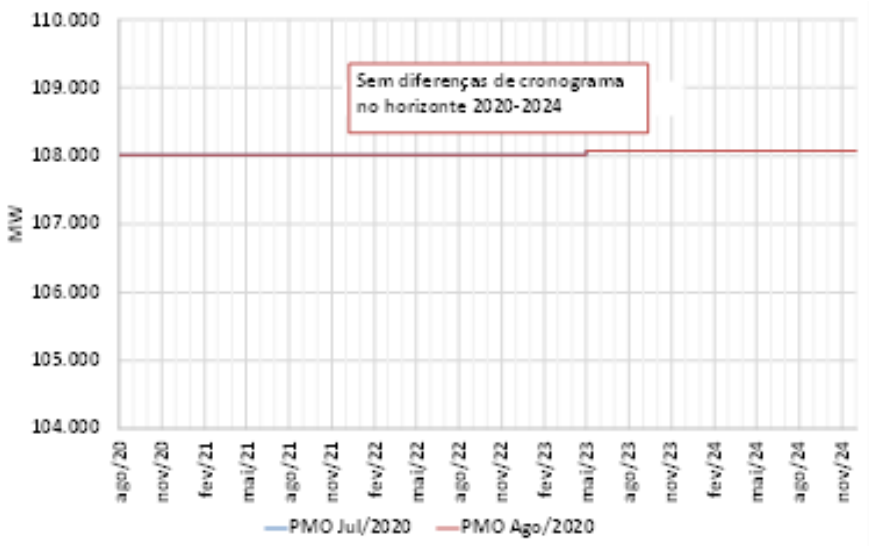

Figura 2 - Evolução da potência instalada das UTEs

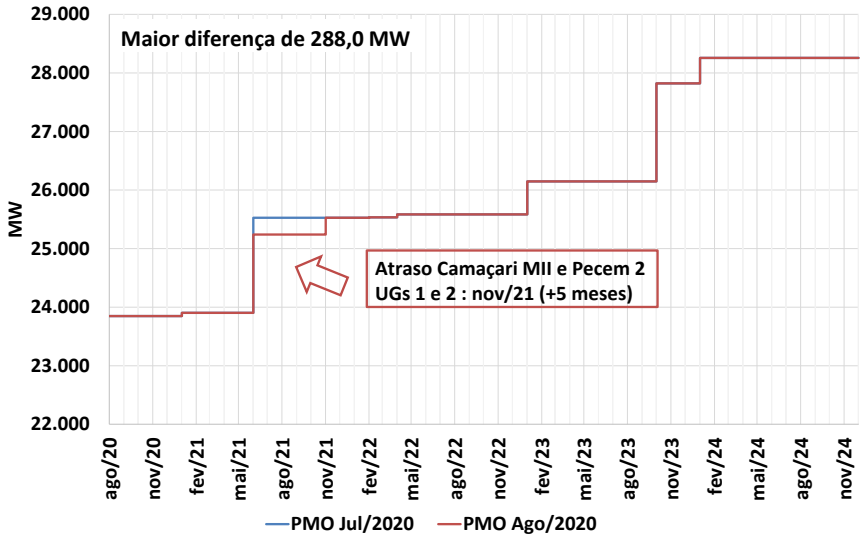

O conteúdo desta publicação foi produzido pelo ONS com base em dados e informações de conhecimento público. É de responsabilidade exclusiva dos agentes e demais interessados a obtenção de outros dados e informações, a realização de análises, estudos e avaliações para fins de tomada de decisões, definição de estratégias de atuação, assunção de compromissos e obrigações e quaisquer outras finalidades, em qualquer tempo e sob qualquer condição. É proibida a reprodução ou utilização total ou parcial do presente sem a identificação da fonte.

Figura 3 - Evolução da disponibilidade das usinas não simuladas

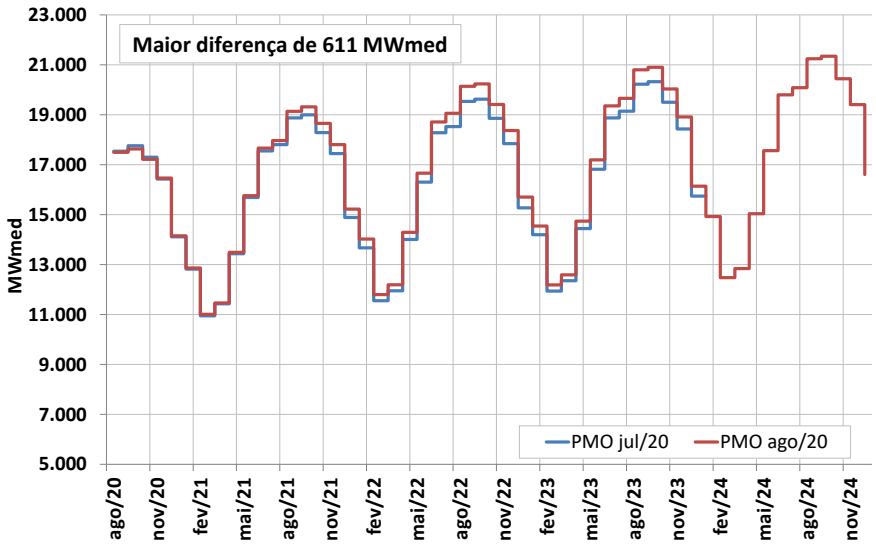

3.1.2. Armazenamentos Iniciais

Na **Figura 4**, a seguir, são apresentados os armazenamentos iniciais equivalentes por subsistema, considerados nos modelos de otimização para a elaboração do PMO de agosto/2020, comparados com os do PMO de julho/2020.

Figura 4 - Energia armazenada inicial em julho/20 e agosto/20 – [% EARmáx]

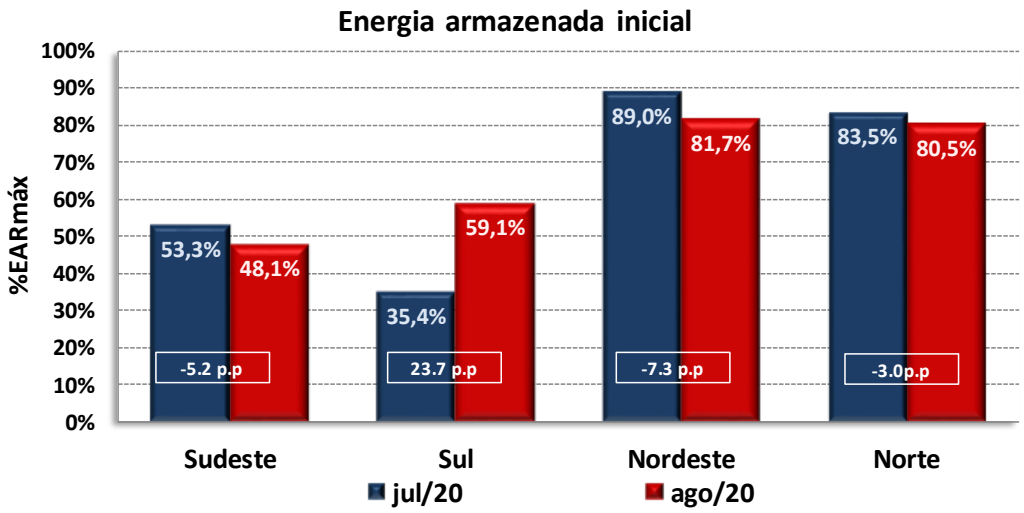

3.1.3. Tendência Hidrológica

Na **Tabela 1**, a seguir, são apresentadas as tendências hidrológicas consideradas pelo modelo NEWAVE para o PMO de agosto/2020, comparadas com o PMO de julho/2020.

O conteúdo desta publicação foi produzido pelo ONS com base em dados e informações de conhecimento público. É de responsabilidade exclusiva dos agentes e demais interessados a obtenção de outros dados e informações, a realização de análises, estudos e avaliações para fins de tomada de decisões, definição de estratégias de atuação, assunção de compromissos e obrigações e quaisquer outras finalidades, em qualquer tempo e sob qualquer condição. É proibida a reprodução ou utilização total ou parcial do presente sem a identificação da fonte.

Tabela 1 – Tendência hidrológica para o PMO de agosto/2020 – NEWAVE [%MLT]

	PMO julho/2020				PMO agosto/2020			
MÊS	SE/CO	S	NE	N	SE/CO	S	NE	N
Jan/20	75	45	42	59				
fev/20	106	33	82	74	105	33	82	74
mar/20	103	26	100	109	103	26	100	109
abr/20	88	16	103	112	87	16	103	112
mai/20	80	20	80	116	80	20	80	117
jun/20	76	67	73	105	77	68	74	104
jul/20					79	119	71	92

* ≥100% MLT < 100% MLT

3.2. DEMAIS ATUALIZAÇÕES

Adicionalmente, neste PMO ocorreram os seguintes destaques:

- Horizonte de estudo: agosto de 2020 a dezembro de 2024;
- Cronograma de Obras – Reunião DMSE-G de 23/07/2020;
- Enchimento do volume morto do reservatório da UHE Santa Branca Tibagi alterado para jan/2023 (duração de 2 meses), conforme informações da SRG/ANEEL na reunião DMSE-G de 23/07/2020;
- CVUs de UTEs vendedoras em leilão;
- CVUs das UTEs Termopernambuco, NorteFluminense 1, 2, 3 e 4 e Araucária (até 07/10/2020), conforme Despachos SRG/ANEEL nº 2.115/2020, 2.116/2020 e 2.216/2020, respectivamente;
- Postergação da previsão de término da manutenção da UTE Figueira (modernização) de 30/12/2020 para 31/05/2021, com aplicação do CVU atual (475,68 R$/MWh) até mai/21, conforme orientações da SFG/ANEEL;
- Alteração de restrições operativas para as UHEs Dona Francisca, Lajes, Caçu, Barra dos Coqueiros, Itaparica e Marimbondo, de acordo com os FSAR-H enviados pelo Agentes responsáveis;
- Adequação dos valores de transposição da UHE Itaparica conforme valores mensais da Resolução ANA nº125/2019;
- Restrições de defluências das usinas do Rio São Francisco conforme “Informe Sobre O Planejamento e a Programação da Operação dos Aproveitamentos Hidroelétricos da Bacia do Rio São Francisco no PMO de Agosto de 2020”;
- Limites de transmissão entre subsistemas, para os meses de agosto e setembro/2020.

O conteúdo desta publicação foi produzido pelo ONS com base em dados e informações de conhecimento público. É de responsabilidade exclusiva dos agentes e demais interessados a obtenção de outros dados e informações, a realização de análises, estudos e avaliações para fins de tomada de decisões, definição de estratégias de atuação, assunção de compromissos e obrigações e quaisquer outras finalidades, em qualquer tempo e sob qualquer condição. É proibida a reprodução ou utilização total ou parcial do presente sem a identificação da fonte.

4. ANÁLISE DAS CONDIÇÕES HIDROMETEOROLÓGICAS

4.1. PREVISÃO PARA A PRÓXIMA SEMANA

A atuação do sistema de alta pressão associado a uma massa de ar seco nas regiões Sul, Sudeste e Centro-Oeste ocasiona a condição de ausência de precipitação nas bacias hidrográficas de interesse do Sistema Interligado Nacional durante a próxima semana. **(Figura 5)**.

Figura 5 - Precipitação acumulada prevista pelo modelo GEFS (CPTEC/INPE) para o período de 01/08 a 07/08/2020

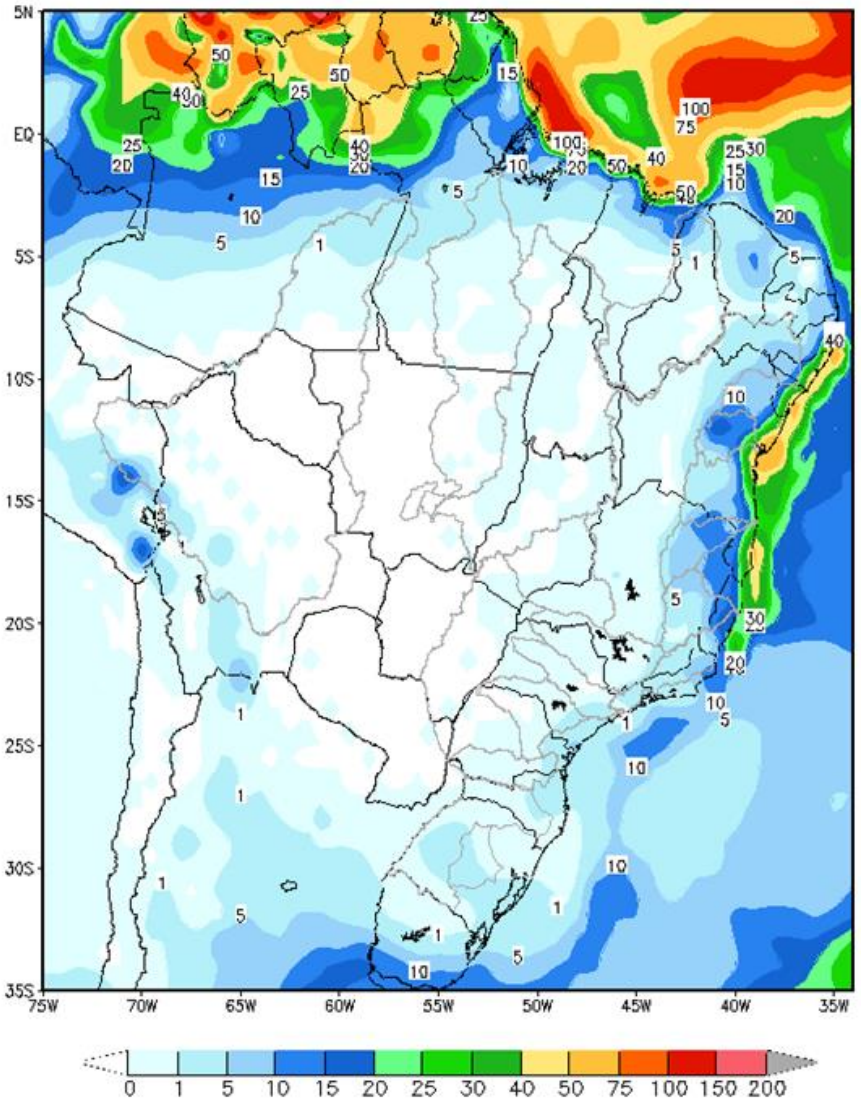

Em comparação com os valores estimados para a semana em curso, prevê-se para a próxima semana operativa recessão nas afluências de todos os subsistemas.

A previsão mensal para agosto indica a ocorrência de afluências abaixo da média histórica para os subsistemas Sudeste, Sul e Nordeste e acima média para o subsistema Norte.

O conteúdo desta publicação foi produzido pelo ONS com base em dados e informações de conhecimento público. É de responsabilidade exclusiva dos agentes e demais interessados a obtenção de outros dados e informações, a realização de análises, estudos e avaliações para fins de tomada de decisões, definição de estratégias de atuação, assunção de compromissos e obrigações e quaisquer outras finalidades, em qualquer tempo e sob qualquer condição. É proibida a reprodução ou utilização total ou parcial do presente sem a identificação da fonte.

Tabela 2 – Previsão de ENAs do PMO de agosto/2020

PMO de Agosto/2020 - ENAs previstas				
Subsistema	1/8 a 7/8/2020		Mês de Agosto	
	MWmed	%MLT	MWmed	%MLT
SE/CO	15.807	77	15.097	73
S	6.035	60	7.009	70
NE	2.378	71	2.194	66
N	3.343	104	2.798	87

5. PREVISÃO DE CARGA

As previsões de carga consolidadas para o PMO de Agosto/2020 foram baseadas na manutenção do comportamento da carga a partir de junho que já sinaliza uma suave elevação em função do início da retomada das atividades econômicas em resposta à flexibilização de algumas medidas restritivas no país, mas ainda segue em patamar bastante inferior ao observado antes do início da pandemia.

As sinalizações meteorológicas indicam para os subsistemas Sudeste/Centro-Oeste e Sul, elevação das temperaturas médias previstas para a próxima semana operativa, quando comparadas às observadas na semana atual nas capitais. Para os subsistemas Nordeste e Norte são esperadas ocorrência de temperaturas e precipitação típicas para essa época do ano e semelhantes às observadas na semana vigente.

As taxas de crescimento previstas para o mês de agosto em relação ao mesmo mês de 2019, são de 1,3% no subsistema Sudeste/Centro-Oeste, 0,9% no subsistema Sul, 2,5% no subsistema Nordeste. Para o subsistema Norte é esperada uma variação negativa de 0,2%, influenciada pela redução de carga de um consumidor livre da rede básica.

Tabela 3 – Evolução da carga do PMO de agosto 2020

Subsistema	CARGA SEMANAL (MWmed)					CARGA MENSAL (MWmed)	
	1ª Sem	2ª Sem	3ª Sem	4ª Sem	5ª Sem	ago/20	Var. (%) ago/20 -> ago/19
Sudeste	37.379	37.487	37.593	37.696	37.836	37.567	1,3%
Sul	10.948	11.117	11.134	11.139	11.168	11.092	0,9%
Nordeste	10.226	10.599	10.636	10.698	10.752	10.560	2,5%
Norte	5.521	5.577	5.638	5.657	5.667	5.605	-0,2%
SIN	64.074	64.779	65.000	65.190	65.423	64.825	1,3%

O conteúdo desta publicação foi produzido pelo ONS com base em dados e informações de conhecimento público. É de responsabilidade exclusiva dos agentes e demais interessados a obtenção de outros dados e informações, a realização de análises, estudos e avaliações para fins de tomada de decisões, definição de estratégias de atuação, assunção de compromissos e obrigações e quaisquer outras finalidades, em qualquer tempo e sob qualquer condição. É proibida a reprodução ou utilização total ou parcial do presente sem a identificação da fonte.

6. PRINCIPAIS RESULTADOS

6.1. CUSTO MARGINAL DE OPERAÇÃO (CMO)

A tabela a seguir apresenta o CMO, por subsistema e patamar de carga para próxima semana operativa.

Tabela 4 – CMO por patamar de carga

Patamares de Carga	CMO (R$/MWh)			
	SE/CO	S	NE	N
Pesada	92,76	92,76	64,47	88,94
Média	91,19	91,19	64,47	88,94
Leve	88,94	88,94	64,24	88,94
Média Semanal	90,75	90,75	64,37	88,94

Na figura a seguir é apresentada a evolução do CMO médio semanal ao longo deste PMO.

Figura 6 – Evolução semanal do CMO

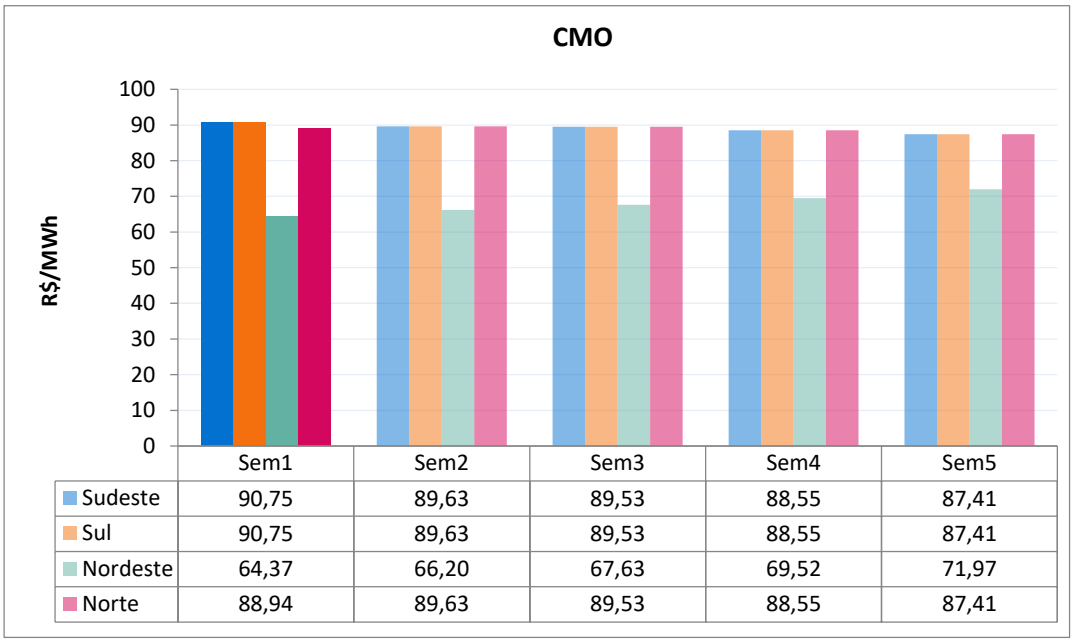

6.2. POLÍTICA DE OPERAÇÃO ENERGÉTICA

Para esta semana operativa, está prevista a seguinte política de intercâmbio de energia entre regiões:

Região SE/CO → Geração dimensionada para fechamento do balanço energético do SIN.

Região Sul → Geração dimensionada de forma a otimizar os recursos desta região.

Região NE → Intercâmbio de energia definido em função dos recursos energéticos da região, respeitando-se os limites elétricos vigentes para o subsistema.

Região Norte → Geração dimensionada de forma a otimizar os recursos desta região e buscando-se a aderência a curva guia para o armazenamento da UHE Tucuruí.

O conteúdo desta publicação foi produzido pelo ONS com base em dados e informações de conhecimento público. É de responsabilidade exclusiva dos agentes e demais interessados a obtenção de outros dados e informações, a realização de análises, estudos e avaliações para fins de tomada de decisões, definição de estratégias de atuação, assunção de compromissos e obrigações e quaisquer outras finalidades, em qualquer tempo e sob qualquer condição. É proibida a reprodução ou utilização total ou parcial do presente sem a identificação da fonte.

7. ANÁLISE DA VARIAÇÃO SEMANAL DO CMO

Esta análise visa identificar os principais parâmetros cujas atualizações impactaram os CMO deste PMO, em comparação com os valores obtidos na última revisão.

Foram realizados 7 estudos, onde caso inicial foi construído com base nos dados preliminares para este PMO, porém ainda utilizando a Função de Custo Futuro elaborada no PMO anterior. Neste primeiro estudo foram retiradas as restrições de limites conjunturais e a partida dos reservatórios foi estimada conforme indicado para esta semana na última revisão do PMO anterior.

O segundo estudo foi realizado com os dados do caso inicial sendo substituída previsão de vazões e em seguida a Função de Custo Futuro anterior pela nova Função elaborada para este PMO.

A partir do conjunto de dados do segundo estudo foram elaborados os demais casos onde foram atualizados, sequencialmente, as seguintes informações: partida dos reservatórios, previsão de carga, disponibilidade das usinas térmicas e hidráulicas, limites elétricos e restrições hidráulicas.

Nos subsistemas Sudeste/Centro-Oeste e Sul não houve variação significativa do CMO do patamar de carga pesada, em relação à Revisão 4 do PMO de Julho. Nos patamares de carga média e leve o acoplamento da nova Função de Custo Futuro foi o fator preponderante a esta redução do CMO.

Figura 7 – Análise da variação do CMO nos subsistemas SE/CO e Sul

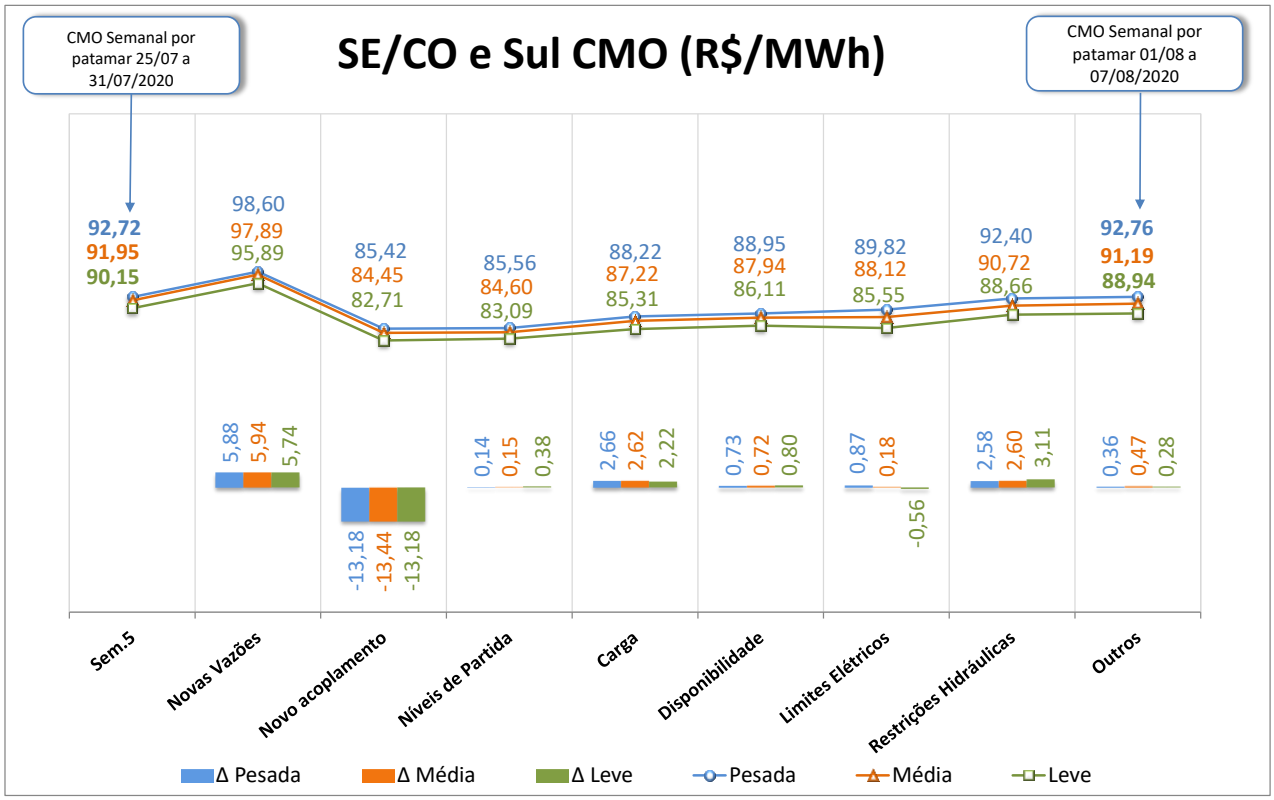

O conteúdo desta publicação foi produzido pelo ONS com base em dados e informações de conhecimento público. É de responsabilidade exclusiva dos agentes e demais interessados a obtenção de outros dados e informações, a realização de análises, estudos e avaliações para fins de tomada de decisões, definição de estratégias de atuação, assunção de compromissos e obrigações e quaisquer outras finalidades, em qualquer tempo e sob qualquer condição. É proibida a reprodução ou utilização total ou parcial do presente sem a identificação da fonte.

Para os subsistemas Nordeste e Norte, apesar de atualização da previsão de vazões indicar uma elevação do CMO, a nova Função de Custo Futuro impactou significativamente no decréscimo do CMO nesses subsistemas, sendo o principal fator a influenciar na redução desse custo.

Figura 8 – Análise da variação do CMO nos subsistemas Nordeste

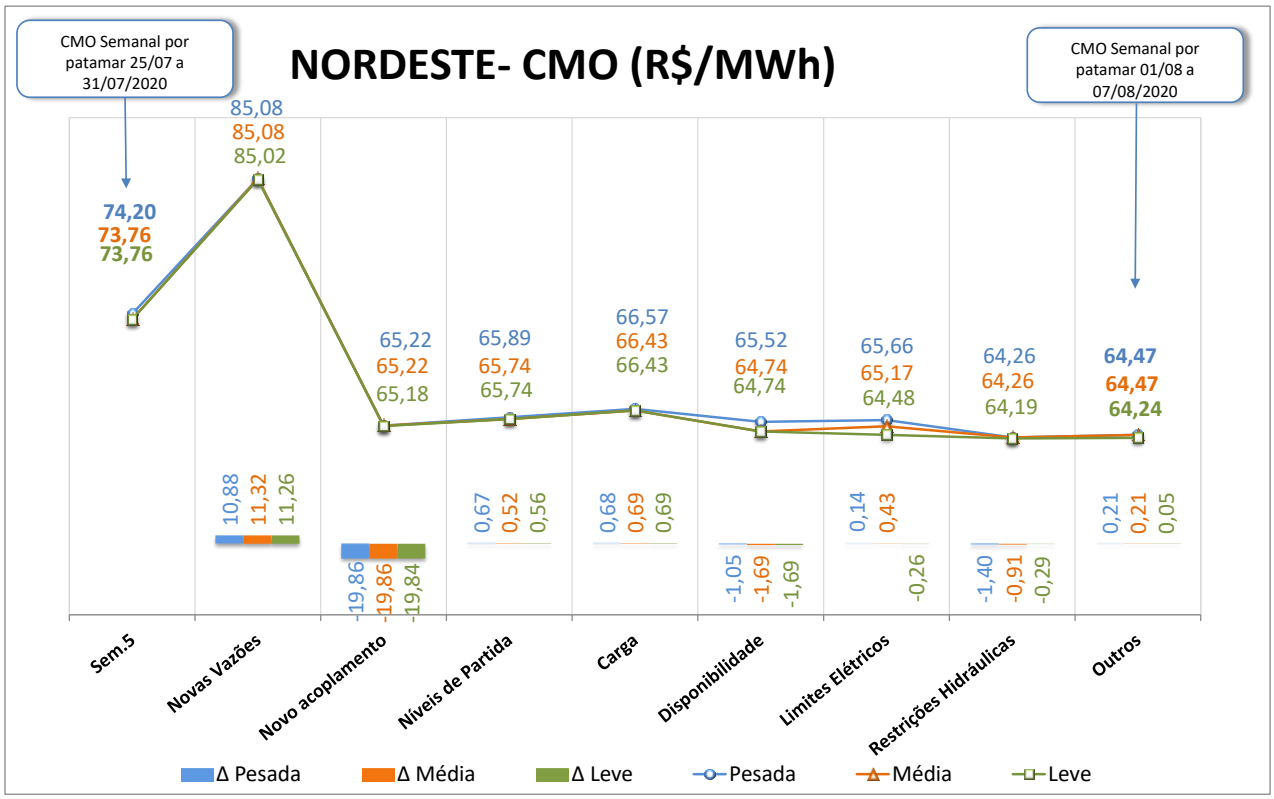

Figura 9 – Análise da variação do CMO nos subsistemas Norte

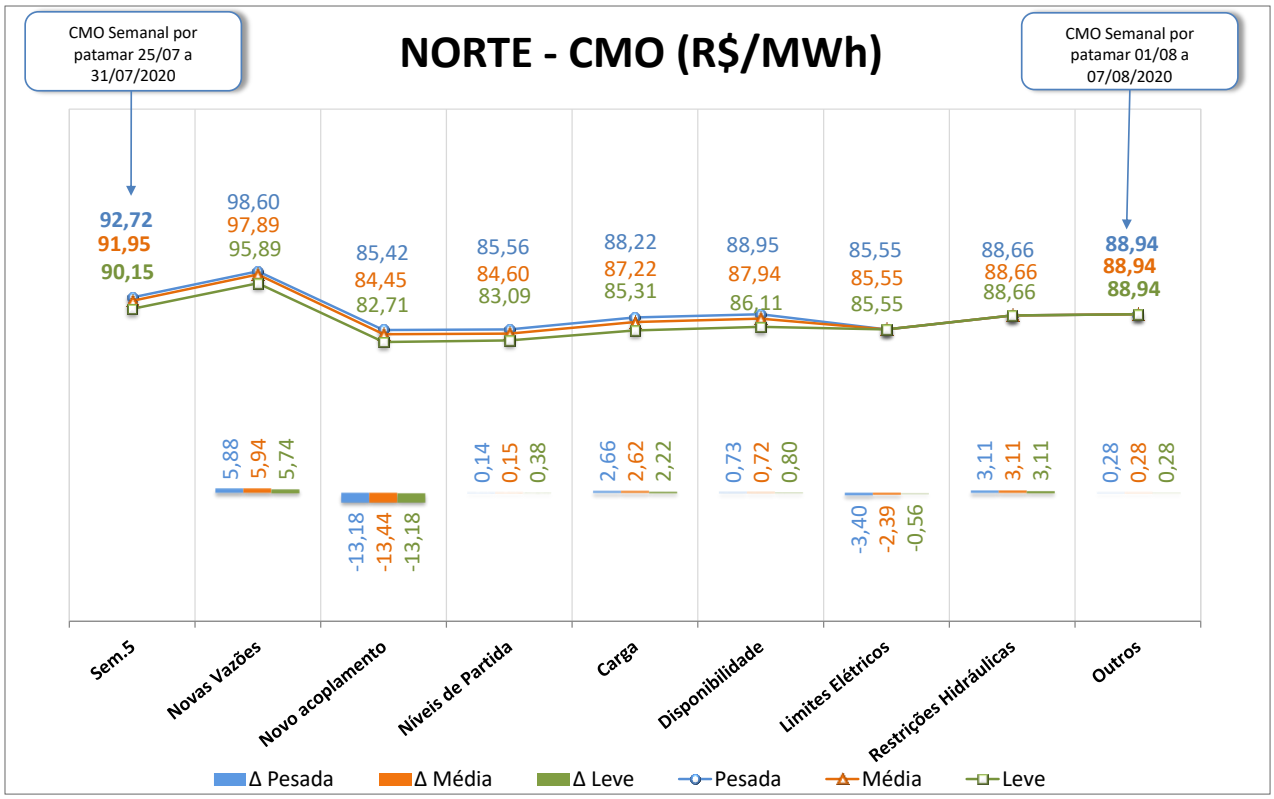

O conteúdo desta publicação foi produzido pelo ONS com base em dados e informações de conhecimento público. É de responsabilidade exclusiva dos agentes e demais interessados a obtenção de outros dados e informações, a realização de análises, estudos e avaliações para fins de tomada de decisões, definição de estratégias de atuação, assunção de compromissos e obrigações e quaisquer outras finalidades, em qualquer tempo e sob qualquer condição. É proibida a reprodução ou utilização total ou parcial do presente sem a identificação da fonte.

8. GERAÇÃO TÉRMICA

A Figura 10 apresenta, para cada subsistema, o despacho térmico por modalidade, para a próxima semana operativa.

Figura 10 – Geração térmica para a próxima semana operativa

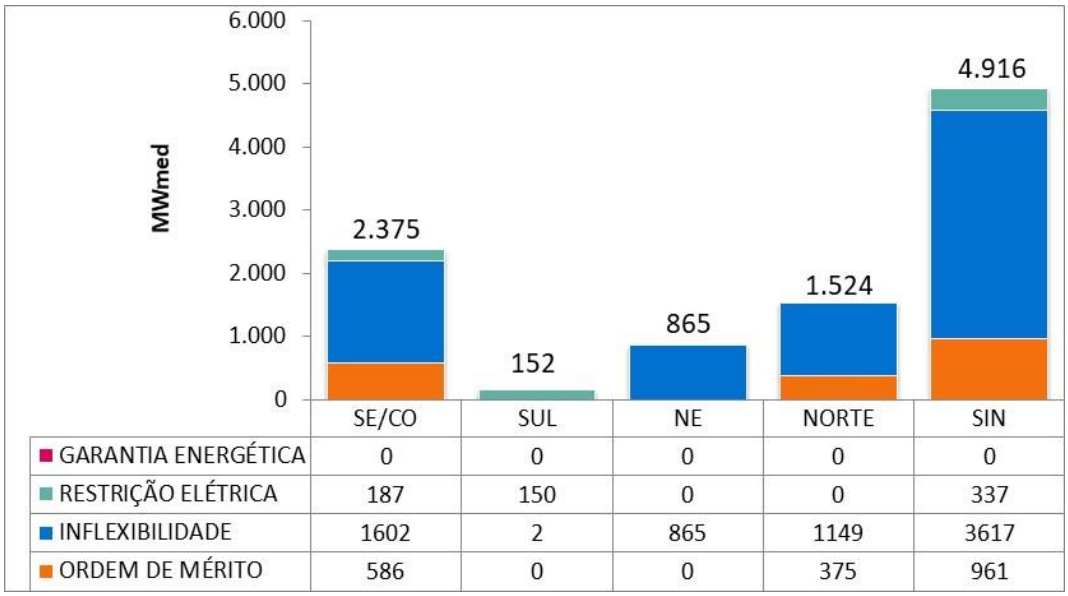

Na tabela abaixo segue a Indicação de despacho antecipado por ordem de mérito de custo para a semana de 03/10/2020 a 09/10/2020.

Tabela 5 – UTEs com contrato de combustível GNL

UTE			Benefício (R$/MWh)		
Nome	Cod	CVU (R$/MWh)	Carga Pesada	Carga Média	Carga Leve
SANTA CRUZ	86	103,50	72,19 (2)	72,19 (2)	72,17 (2)
LUIZORMELO	15	151,05	72,19 (2)	72,19 (2)	72,17 (2)
PSERGIPE I	224	187,78	71,28 (2)	67,52 (2)	67,52 (2)

(1) Comandado o despacho antecipado por ordem de mérito de custo nesse patamar

(2) NÃO foi comandado o despacho antecipado por ordem de mérito de custo nesse patamar

Apesar da UTE Luiz O. R. Melo não estar despachada por ordem de mérito, há necessidade do despacho de, pelo menos, 204 MW dessa usina para reduzir o risco de corte de carga na região de Governador Valadares e na região Norte do Espírito Santo. Desta forma, a UTE Luiz O. R. Melo deverá ser despachada por razão elétrica, na referida semana, em 204 MW.

O conteúdo desta publicação foi produzido pelo ONS com base em dados e informações de conhecimento público. É de responsabilidade exclusiva dos agentes e demais interessados a obtenção de outros dados e informações, a realização de análises, estudos e avaliações para fins de tomada de decisões, definição de estratégias de atuação, assunção de compromissos e obrigações e quaisquer outras finalidades, em qualquer tempo e sob qualquer condição. É proibida a reprodução ou utilização total ou parcial do presente sem a identificação da fonte.

9. IMPORTAÇÃO DE ENERGIA DA REPÚBLICA ORIENTAL DO URUGUAI

9.1. República Oriental do Uruguai

Para a próxima semana operativa, foram declaradas as seguintes ofertas de importação de energia da República Oriental do Uruguai para o Sistema Interligado Nacional - SIN através das conversoras de Rivera (70 MW) e Melo (500 MW).

- **Eletrobras**

Tabela 6 – Energia Ofertada para Importação

	Oferta de Energia para a Semana de 1/8 a 7/8 (MWmed)			
	Bloco 1	Bloco 2	Bloco 3	Total
Carga Pesada	70,0	60,0	190,0	320,0
Carga Média	70,0	60,0	190,0	320,0
Carga Leve	70,0	60,0	190,0	320,0
CVU (R$/MWh)	149,47	249,99	692,71	

Conforme declaração do agente, a conversora de Rivera terá sua capacidade de transferência de potência reduzida para 45 MW no dia 05/08/2020 das 07:00 a 14:00 horas.

- **Enel**

Tabela 7 – Energia Ofertada para Importação

	Oferta de Energia para a Semana de 1/8 a 7/8 (MWmed)		
	Bloco 1	Bloco 2	Total
Carga Pesada	60,0	190,0	250,0
Carga Média	60,0	190,0	250,0
Carga Leve	60,0	190,0	250,0
CVU (R$/MWh)	254,47	703,63	

Conforme declaração do agente, esta importação poderá ser realizada exclusivamente pela conversora Melo.

9.2. República da Argentina

Para a semana operativa de 01/08/2020 a 07/08/2020, não houve oferta de importação de energia da República da Argentina.

Nota: Detalhes sobre a importação de energia vide Portaria Nº 339, de 15 de Agosto de 2018 disponível em: http://pesquisa.in.gov.br/imprensa/jsp/visualiza/index.jsp?data=17/08/2018&jornal=515&pagina=60&totalArquivos=136

O conteúdo desta publicação foi produzido pelo ONS com base em dados e informações de conhecimento público. É de responsabilidade exclusiva dos agentes e demais interessados a obtenção de outros dados e informações, a realização de análises, estudos e avaliações para fins de tomada de decisões, definição de estratégias de atuação, assunção de compromissos e obrigações e quaisquer outras finalidades, em qualquer tempo e sob qualquer condição. É proibida a reprodução ou utilização total ou parcial do presente sem a identificação da fonte.

10. ESTIMATIVA DE ENCARGOS OPERATIVOS

A tabela a seguir apresenta a expectativa do custo de despacho térmico por restrição elétrica para esta semana operativa.

Tabela 8 – Expectativa de custo de despacho térmico por Restrição Elétrica

UTE Potência Instalada (MW)	CVU (R$/MWh)	Geração (MWmed)			ESS ELÉTRICO
		Carga Pesada	Carga Média	Carga Leve	
LUIZORMELO (204)	R$ 151,05	187,0	187,0	187,0	**R$ 1.894.502,61**
TOTAL SE/CO					**R$ 1.894.502,61**

11. ARMAZENAMENTOS OPERATIVOS

Para uma melhor avaliação de diversos cenários hidrometeorológicos, notadamente, aqueles de curto prazo e suas influências nas previsões de vazões nos subsistemas, os resultados deste PMO contemplam cenários de afluências visando melhor representar a ocorrência de precipitação e, consequentemente, seus efeitos sobre as afluências e armazenamentos.

Além dos resultados associados ao valor esperado das previsões de afluências, as simulações operativas também foram realizadas com os limites superior e inferior das previsões de afluências. Apresentamos a seguir os resultados obtidos com a aplicação dos diferentes cenários de afluência.

Tabela 9 – Previsão de ENA dos cenários de sensibilidade

Subsistema	ENERGIAS NATURAIS AFLUENTES					
	Previsão Mensal					
	LI		VE		LS	
	(MWmed)	%MLT	(MWmed)	%MLT	(MWmed)	%MLT
Sudeste	13.210	**64**	15.097	**73**	16.975	**82**
Sul	2.959	**29**	7.009	**70**	11.934	**118**
Nordeste	2.045	**61**	2.194	**66**	2.342	**70**
Norte	2.586	**80**	2.798	**87**	3.009	**93**

Tabela 10 – Previsão de %EARmáx para o final do mês

Subsistema	% EARmáx 31/7	% EARmáx - 31/8		
	NÍVEL INICIAL	NÍVEL PMO		
	VE	LI	VE	LS
Sudeste	**47,9**	**41,7**	**43,2**	**44,6**
Sul	**59,1**	**37,1**	**45,2**	**54,9**
Nordeste	**81,7**	**68,3**	**68,6**	**69,0**
Norte	**80,5**	**69,0**	**69,3**	**69,7**

O conteúdo desta publicação foi produzido pelo ONS com base em dados e informações de conhecimento público. É de responsabilidade exclusiva dos agentes e demais interessados a obtenção de outros dados e informações, a realização de análises, estudos e avaliações para fins de tomada de decisões, definição de estratégias de atuação, assunção de compromissos e obrigações e quaisquer outras finalidades, em qualquer tempo e sob qualquer condição. É proibida a reprodução ou utilização total ou parcial do presente sem a identificação da fonte.

12. RESERVATÓRIOS EQUIVALENTES DE ENERGIA

A seguir são apresentadas as previsões de Energia Natural Afluente para a próxima semana operativa e para o mês de agosto, bem como as previsões de Energia Armazenada nos Reservatórios Equivalentes de Energia – REE, deste PMO.

Tabela 11 – Previsão de ENA por REE

Valor Esperado das Energias Naturais Afluentes				
REE	Previsão Semanal		Previsão Mensal	
	01/08/2020 a 07/08/2020		ago/20	
	(MWmed)	%MLT	(MWmed)	%MLT
Sudeste	1.948	79	1.881	76
Madeira	2.129	89	1.816	76
Teles Pires	545	70	509	66
Itaipu	1.924	74	1.948	74
Paraná	8.443	80	8.051	77
Paranapanema	786	42	868	46
Sul	4.594	77	5.196	87
Iguaçu	1.442	35	1.812	44
Nordeste	2.379	71	2.194	66
Norte	1.503	81	1.353	73
Belo Monte	965	143	676	100
Manaus	942	134	803	114

Tabela 12 – Previsão de %EARmáx por REE

% Energia Armazenável Máxima		
REE	Previsão Semanal	Previsão Mensal
	7-ago	31-ago
	(%EARmáx)	(%EARmáx)
Sudeste	41,8	38,0
Madeira	56,8	41,0
Teles Pires	18,9	16,0
Itaipu	30,7	97,6
Paraná	49,7	45,6
Paranapanema	36,7	36,4
Sul	75,2	67,8
Iguaçu	38,3	24,8
Nordeste	79,2	68,6
Norte	79,7	70,6
Belo Monte	100,0	96,4
Manaus	52,0	44,4

O conteúdo desta publicação foi produzido pelo ONS com base em dados e informações de conhecimento público. É de responsabilidade exclusiva dos agentes e demais interessados a obtenção de outros dados e informações, a realização de análises, estudos e avaliações para fins de tomada de decisões, definição de estratégias de atuação, assunção de compromissos e obrigações e quaisquer outras finalidades, em qualquer tempo e sob qualquer condição. É proibida a reprodução ou utilização total ou parcial do presente sem a identificação da fonte.

13. DESPACHO TÉRMICO POR MODALIDADE, PATAMAR DE CARGA E USINA

Nas tabelas abaixo, a diferenciação entre geração por inflexibilidade e por ordem de mérito tem caráter informativo, com o objetivo de detalhar a informação de inflexibilidade enviada pelos respectivos agentes para o PMO. Ressalta-se que nas etapas de Programação Diária e Tempo Real, o montante despachado nas usinas termelétricas indicadas por ordem de mérito é plenamente intitulado como ordem de mérito.

REGIÃO SUDESTE/CENTRO-OESTE																	
Combustível	Combustível	CVU (R$/MWh)	Inflexibilidade			Ordem de Mérito			Total Mérito e INFL.			Razão Elétrica			Total UTE		
			P	M	L	P	M	L	P	M	L	P	M	L	P	M	L
ATLAN_CSA (255)	Resíduos	0,00	141,2	141,2	141,2				141,2	141,2	141,2				141,2	141,2	141,2
ANGRA 2 (1350)	Nuclear	20,12	540,0	450,0	252,0	0,0	0,0	0,0	540,0	450,0	252,0				540,0	450,0	252,0
ANGRA 1 (640)	Nuclear	31,17	640,0	640,0	640,0	0,0	0,0	0,0	640,0	640,0	640,0				640,0	640,0	640,0
NORTEFLU 1 (400)	Gás	83,15				400,0	400,0	400,0	400,0	400,0	400,0				400,0	400,0	400,0
BAIXADA FL (530)	Gás	91,57				520,0			520,0						520,0		
NORTEFLU 2 (100)	Gás	94,21															
SANTA CRUZ (500)	GNL	103,50															
UTE STA VI (41)	Biomassa	116,91	13,0	13,0	13,0				13,0	13,0	13,0				13,0	13,0	13,0
LUIZORMELO (204)	GNL	151,05										187,0	187,0	187,0	187,0	187,0	187,0
NORTEFLU 3 (200)	Gás	180,11															
ATLANTICO (235)	Resíduos	192,23	218,7	218,7	218,7				218,7	218,7	218,7				218,7	218,7	218,7
T.LAGOAS (350)	Gás	224,29															
TERMORIO (1036)	Gás	267,47	150,0	150,0	150,0				150,0	150,0	150,0				150,0	150,0	150,0
JUIZ DE FO (87)	Gás	283,74															
ST.CRUZ 34 (436)	Óleo	310,41															
CUBATAO (216)	Gás	333,31	45,0	45,0	45,0				45,0	45,0	45,0				45,0	45,0	45,0
SEROPEDICA (386)	Gás	343,38															
IBIRITE (226)	Gás	346,37															
NORTEFLU 4 (127)	Gás	369,80															
CUIABA CC (529)	Gás	377,54															
PIRAT.12 O (200)	Gás	470,34															
VIANA (175)	Óleo	528,92															
NPIRATINGA (572)	Gás	548,04															
T.MACAE (929)	Gás	611,82															
TNORTE 2 (340)	Óleo	910,86															
PALMEIR_GO (176)	Diesel	924,72															
IGARAPE (131)	Óleo	939,55															
CAMPOS (25)	Gás	978,10															
DAIA (44)	Diesel	1178,36															
GOIANIA 2 (140)	Diesel	1235,54															
XAVANTES (54)	Diesel	1694,77															
TOTAL SE/CO (10634)			1747,90	1657,90	1459,90	920,0	400,0	400,0	2667,9	2057,9	1859,9	187,0	187,0	187,0	2854,9	2244,9	2046,9

REGIÃO SUL																	
Combustível	Combustível	CVU (R$/MWh)	Inflexibilidade			Ordem de Mérito			Total Mérito e INFL.			Razão Elétrica			Total UTE		
			P	M	L	P	M	L	P	M	L	P	M	L	P	M	L
PAMPA SUL (345)	Carvão	67,12				0,0	0,0	0,0	0,0	0,0	0,0				0,0	0,0	0,0
SAO SEPE (8)	Biomassa	84,44				0,0	0,0	0,0	0,0	0,0	0,0				0,0	0,0	0,0
CANDIOTA_3 (350)	Carvão	86,37				0,0	0,0	0,0	0,0	0,0	0,0				0,0	0,0	0,0
J.LACER. C (363)	Carvão	206,84															
J.LACER. B (262)	Carvão	244,14										80,0	80,0	80,0	80,0	80,0	80,0
J.LAC. A2 (132)	Carvão	245,21										70,0	70,0	70,0	70,0	70,0	70,0
J.LAC. A1 (100)	Carvão	270,48															
URUGUAIANA (640)	Gás	278,48															
MADEIRA (4)	Biomassa	308,66	2,0	2,0	2,0				2,0	2,0	2,0				2,0	2,0	2,0
FIGUEIRA (20)	Carvão	475,68															
ARAUCARIA (484)	Gás	614,75															
CANOAS (249)	Diesel	698,14															
TOTAL SUL (2957)			2,00	2,00	2,00	0,0	0,0	0,0	2,0	2,0	2,0	150,0	150,0	150,0	152,0	152,0	152,0

O conteúdo desta publicação foi produzido pelo ONS com base em dados e informações de conhecimento público. É de responsabilidade exclusiva dos agentes e demais interessados a obtenção de outros dados e informações, a realização de análises, estudos e avaliações para fins de tomada de decisões, definição de estratégias de atuação, assunção de compromissos e obrigações e quaisquer outras finalidades, em qualquer tempo e sob qualquer condição. É proibida a reprodução ou utilização total ou parcial do presente sem a identificação da fonte.

REGIÃO NORDESTE

Combustível	Combustível	CVU (R$/MWh)	Inflexibilidade			Ordem de Mérito			Total Mérito e INFL.			Razão Elétrica			Total UTE		
			P	M	L	P	M	L	P	M	L	P	M	L	P	M	L
P.PECEM1 (720)	Carvão	141,30															
P.PECEM2 (365)	Carvão	153,07															
PROSPERIDA (28)	Gás	159,37															
T.BAHIA (186)	Gás	159,52	150,0	150,0	150,0				150,0	150,0	150,0				150,0	150,0	150,0
VALE ACU (368)	Gás	165,38	155,0	155,0	155,0				155,0	155,0	155,0				155,0	155,0	155,0
TERMOPE (533)	Gás	177,66	532,7	532,7	532,7				532,7	532,7	532,7				532,7	532,7	532,7
FORTALEZA (327)	Gás	180,57															
PSERGIPE I (1516)	GNL	187,78															
T.CAMACARI (120)	Gás	345,02															
TERMOCEARA (223)	Gás	370,82															
PERNAMBU_3 (201)	Óleo	446,42															
MARACANAU (168)	Óleo	508,56															
SYKUE I (30)	Biomassa	510,12	27,0	27,0	27,0				27,0	27,0	27,0				27,0	27,0	27,0
TERMOCABO (50)	Óleo	522,68															
SUAPE II (381)	Óleo	526,52															
TERMONE (171)	Óleo	528,68															
TERMOPB (171)	Óleo	528,68															
CAMPINA_GR (169)	Óleo	528,93															
GLOBAL I (149)	Óleo	600,78															
GLOBAL II (149)	Óleo	600,78															
BAHIA_1 (31)	Óleo	730,86															
ALTOS (13)	Diesel	1023,94															
ARACATI (11)	Diesel	1023,94															
BATURITE (11)	Diesel	1023,94															
C.MAIOR (13)	Diesel	1023,94															
CAUCAIA (15)	Diesel	1023,94															
CRATO (13)	Diesel	1023,94															
IGUATU (15)	Diesel	1023,94															
JUAZEIRO N (15)	Diesel	1023,94															
MARAMBAIA (13)	Diesel	1023,94															
NAZARIA (13)	Diesel	1023,94															
PECEM (15)	Diesel	1023,94															
AREMBEPE (150)	Óleo	1167,07															
MURICY (147)	Óleo	1167,07															
POTIGUAR_3 (66)	Diesel	1222,81															
POTIGUAR (53)	Diesel	1222,82															
PETROLINA (136)	Óleo	1280,44															
PAU FERRO (94)	Diesel	1379,18															
TERMOMANAU (143)	Diesel	1379,18															
TOTAL NE (6992)			864,70	864,70	864,70	0,0	0,0	0,0	864,7	864,7	864,7	0,0	0,0	0,0	864,7	864,7	864,7

REGIÃO NORTE

Combustível	Combustível	CVU (R$/MWh)	Inflexibilidade			Ordem de Mérito			Total Mérito e INFL.			Razão Elétrica			Total UTE		
			P	M	L	P	M	L	P	M	L	P	M	L	P	M	L
C. ROCHA (85)	Gás	0,00	65,0	65,0	65,0				65,0	65,0	65,0				65,0	65,0	65,0
JARAQUI (75)	Gás	0,00	63,0	63,0	63,0				63,0	63,0	63,0				63,0	63,0	63,0
MANAUARA (67)	Gás	0,00	64,5	64,5	64,5				64,5	64,5	64,5				64,5	64,5	64,5
PONTA NEGR (66)	Óleo	0,00	64,0	64,0	64,0				64,0	64,0	64,0				64,0	64,0	64,0
TAMBAQUI (93)	Óleo	0,00	63,0	63,0	63,0				63,0	63,0	63,0				63,0	63,0	63,0
APARECIDA (166)	Gás	58,99	75,00	75,00	75,00	48,0	48,0	48,0	123,0	123,0	123,0				123,0	123,0	123,0
UTE MAUA 3 (591)	Gás	58,99	264,00	264,00	264,00	326,8	326,8	326,8	590,8	590,8	590,8				590,8	590,8	590,8
MARANHAO3 (519)	Carvão	82,48	490,0	490,0	490,0	0,0	0,0	0,0	490,0	490,0	490,0				490,0	490,0	490,0
MARANHAO V (338)	Gás	97,45															
MARANHAOIV (338)	Gás	97,45															
P. ITAQUI (360)	Gás	147,67															
PARNAIB_IV (56)	Gás	151,69															
N.VENECIA2 (270)	Gás	223,51															
GERAMAR1 (166)	Gás	528,91															
GERAMAR2 (166)	Gás	528,91															
TOTAL NORTE (3356)			1148,5	1148,5	1148,5	374,8	374,8	374,8	1523,3	1523,3	1523,3	0,0	0,0	0,0	1523,3	1523,3	1523,3

O conteúdo desta publicação foi produzido pelo ONS com base em dados e informações de conhecimento público. É de responsabilidade exclusiva dos agentes e demais interessados a obtenção de outros dados e informações, a realização de análises, estudos e avaliações para fins de tomada de decisões, definição de estratégias de atuação, assunção de compromissos e obrigações e quaisquer outras finalidades, em qualquer tempo e sob qualquer condição. É proibida a reprodução ou utilização total ou parcial do presente sem a identificação da fonte.