1. APRESENTAÇÃO

Na semana de 01/08 a 07/08 houve estiagem nas bacias hidrográficas de interesse do SIN.

Na semana de 08/08 a 14/08/2020 deve ocorrer chuva fraca nas bacias dos rios Jacuí, Uruguai, Iguaçu e na incremental a UHE Itaipu.

Para a semana operativa de 08/08 a 14/08/2020, houve oferta de energia da República Oriental do Uruguai. De acordo com o Art. 2º da Portaria MME nº 339, de 15 de agosto de 2018, as ofertas para importação de energia não foram consideradas na elaboração do PMO. Para a referida semana, não houve oferta de energia da República da Argentina.

Os valores médios semanais do Custo Marginal de Operação – CMO dos subsistemas do SIN sofreram as seguintes alterações em relação à semana anterior:

- SE/CO: de R$ 90,75/MWh para R$ 99,51/MWh
- Sul: de R$ 90,75/MWh para R$ 99,51/MWh
- Nordeste: de R$ 64,37/MWh para R$ 67,85/MWh
- Norte: de R$ 88,94/MWh para R$ 99,51/MWh

Desde o dia 01/01/2020, o despacho por ordem de mérito é indicado diariamente pelos resultados do modelo DESSEM. Assim, o despacho por ordem de mérito semanal, conforme publicado nesse documento, tem caráter apenas informativo.

2. NOTÍCIAS

Nos dias 27 e 28 de agosto será realizada a reunião de elaboração do PMO Setembro de 2020, com transmissão ao vivo através do site do ONS.

Como medida adicional de prevenção ao Coronavírus, o ONS informa que está suspensa, temporariamente, a participação presencial nas reuniões.

3. ANÁLISE DAS CONDIÇÕES HIDROMETEOROLÓGICAS

3.1. PREVISÃO PARA A PRÓXIMA SEMANA

A atuação de áreas de instabilidade na região Sul e o avanço de uma nova frente fria no final da próxima semana ocasionam chuva fraca nas bacias dos rios Jacuí, Uruguai, Iguaçu e na incremental a UHE Itaipu **(Figura 1)**.

O conteúdo desta publicação foi produzido pelo ONS com base em dados e informações de conhecimento público. É de responsabilidade exclusiva dos agentes e demais interessados a obtenção de outros dados e informações, a realização de análises, estudos e avaliações para fins de tomada de decisões, definição de estratégias de atuação, assunção de compromissos e obrigações e quaisquer outras finalidades, em qualquer tempo e sob qualquer condição. É proibida a reprodução ou utilização total ou parcial do presente sem a identificação da fonte.

Figura 1 - Precipitação acumulada prevista pelo modelo GEFS (CPTEC/INPE) para o período de 08/08 a 14/08/2020

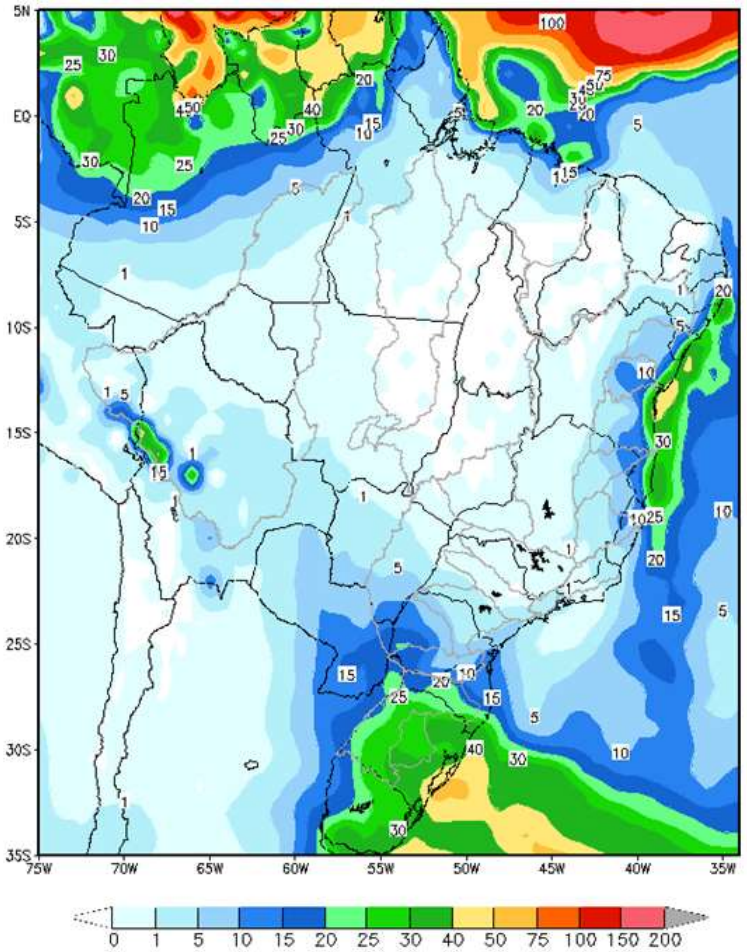

Em comparação com os valores estimados para a semana em curso, prevê-se para a próxima semana operativa recessão nas afluências de todos os subsistemas.

A previsão mensal para agosto indica a ocorrência de afluências abaixo da média histórica para todos os subsistemas.

Tabela 1 – Previsão de ENAs do PMO de agosto/2020

Revisão 1 do PMO de Agosto/2020 - ENAs previstas				
Subsistema	8/8 a 14/8/2020		Mês de Agosto	
	MWmed	%MLT	MWmed	%MLT
SE/CO	15.202	74	15.057	73
S	4.506	45	5.669	56
NE	2.305	69	2.248	67
N	2.585	80	2.442	76

O conteúdo desta publicação foi produzido pelo ONS com base em dados e informações de conhecimento público. É de responsabilidade exclusiva dos agentes e demais interessados a obtenção de outros dados e informações, a realização de análises, estudos e avaliações para fins de tomada de decisões, definição de estratégias de atuação, assunção de compromissos e obrigações e quaisquer outras finalidades, em qualquer tempo e sob qualquer condição. É proibida a reprodução ou utilização total ou parcial do presente sem a identificação da fonte.

4. PREVISÃO DE CARGA

As previsões de carga consolidadas para o PMO de agosto/2020 foram baseadas na manutenção do comportamento da carga a partir de junho que já apresenta suave elevação em função do início da retomada das atividades econômicas em resposta à flexibilização de algumas medidas restritivas no país, mas ainda segue em patamar bastante inferior ao observado antes do início da pandemia. Ressalta-se que a carga do subsistema Nordeste tem se mantido estável em relação às últimas semanas.

Para a próxima semana operativa as sinalizações meteorológicas indicam suaves elevações das temperaturas médias previstas quando comparadas às observadas na semana atual nas capitais das regiões Sudeste/Centro-Oeste e Sul. Para os subsistemas Nordeste e Norte, para a maioria das capitais, são esperadas temperaturas e chuvas típicas para essa época do ano e semelhantes às observadas na semana vigente. Porém, cabe destacar que para as capitais de Belém e Manaus há expectativa de ocorrência de temperaturas elevadas.

As taxas de crescimento previstas para o mês de agosto em relação ao mesmo mês de 2019, são de 1,0% no subsistema Sudeste/Centro-Oeste, 2,3% no subsistema Norte. Para os subsistemas Sul e Nordeste são esperadas, respectivamente, variações negativas de, 2,3% e 1,8%. Ressalta-se que o comportamento da carga do subsistema Nordeste está influenciado pela redução de carga de um CL da rede básica.

Tabela 2 – Evolução da carga do PMO de agosto 2020

Subsistema	CARGA SEMANAL (MWmed)					CARGA MENSAL (MWmed)	
	1ª Sem	2ª Sem	3ª Sem	4ª Sem	5ª Sem	ago/20	Var. (%) ago/20 -> ago/19
Sudeste	37.016	37.487	37.593	37.696	37.836	37.485	1,0%
Sul	10.563	10.783	10.799	10.804	10.832	10.746	-2,3%
Nordeste	10.051	10.088	10.106	10.173	10.216	10.115	-1,8%
Norte	5.733	5.735	5.738	5.752	5.765	5.742	2,3%
SIN	63.363	64.093	64.236	64.425	64.649	64.088	0,1%

O conteúdo desta publicação foi produzido pelo ONS com base em dados e informações de conhecimento público. É de responsabilidade exclusiva dos agentes e demais interessados a obtenção de outros dados e informações, a realização de análises, estudos e avaliações para fins de tomada de decisões, definição de estratégias de atuação, assunção de compromissos e obrigações e quaisquer outras finalidades, em qualquer tempo e sob qualquer condição. É proibida a reprodução ou utilização total ou parcial do presente sem a identificação da fonte.

5. PRINCIPAIS RESULTADOS

5.1. CUSTO MARGINAL DE OPERAÇÃO (CMO)

A tabela a seguir apresenta o CMO, por subsistema e patamar de carga para próxima semana operativa.

Tabela 3 – CMO por patamar de carga

Patamares de Carga	CMO (R$/MWh)			
	SE/CO	S	NE	N
Pesada	100,56	100,56	68,60	100,56
Média	100,31	100,31	67,43	100,31
Leve	98,31	98,31	67,43	98,31
Média Semanal	99,51	99,51	67,85	99,51

Na figura a seguir é apresentada a evolução do CMO médio semanal ao longo deste PMO.

Figura 2 – Evolução semanal do CMO

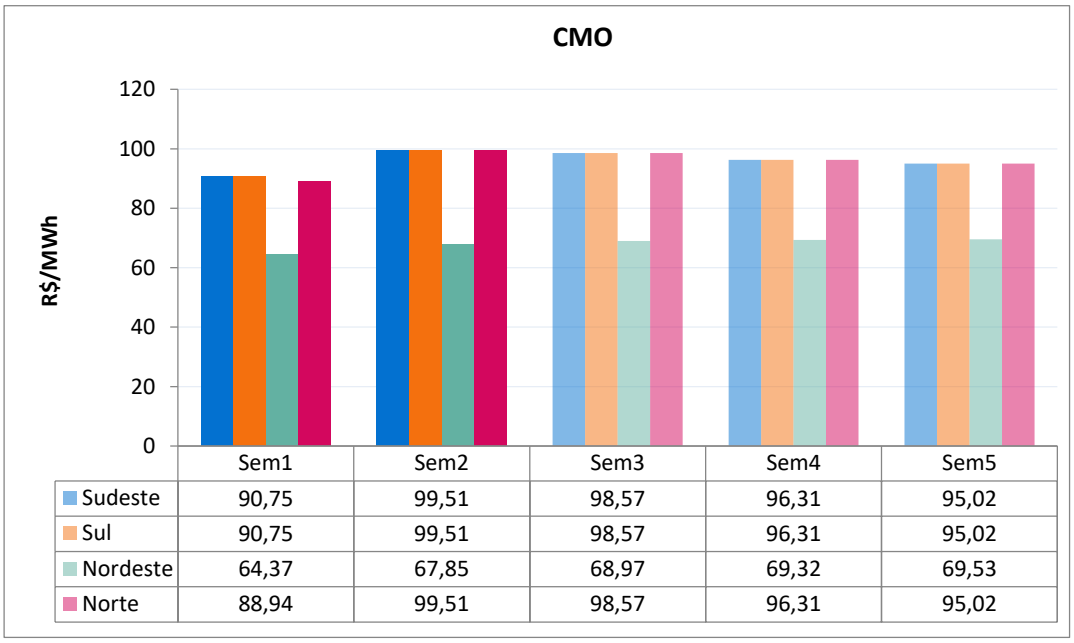

5.2. POLÍTICA DE OPERAÇÃO ENERGÉTICA

Para esta semana operativa, está prevista a seguinte política de intercâmbio de energia entre regiões:

Região SE/CO → Geração dimensionada para fechamento do balanço energético do SIN.

Região Sul → Geração dimensionada de forma a otimizar os recursos desta região.

Região NE → Intercâmbio de energia definido em função dos recursos energéticos da região, respeitando-se os limites elétricos vigentes para o subsistema.

Região Norte → Geração dimensionada de forma a otimizar os recursos desta região e buscando-se a aderência a curva guia para o armazenamento da UHE Tucuruí.

O conteúdo desta publicação foi produzido pelo ONS com base em dados e informações de conhecimento público. É de responsabilidade exclusiva dos agentes e demais interessados a obtenção de outros dados e informações, a realização de análises, estudos e avaliações para fins de tomada de decisões, definição de estratégias de atuação, assunção de compromissos e obrigações e quaisquer outras finalidades, em qualquer tempo e sob qualquer condição. É proibida a reprodução ou utilização total ou parcial do presente sem a identificação da fonte.

6. ANÁLISE DA VARIAÇÃO SEMANAL DO CMO

Esta análise visa identificar os principais parâmetros cujas atualizações impactaram os CMO desta revisão do PMO, em comparação com os valores obtidos na última revisão.

Foram realizados 8 estudos, onde caso inicial foi construído com base nos dados oficiais da última revisão deste PMO. Neste primeiro estudo a partida dos reservatórios foi estimada conforme indicado para esta semana na última revisão.

O segundo estudo foi realizado com os dados do caso inicial sendo substituída previsão de vazões para esta revisão.

A partir do conjunto de dados do segundo estudo foram elaborados os demais casos onde foram atualizados, sequencialmente, as seguintes informações: níveis de partida dos reservatórios, previsão de carga, oferta térmica, limites elétricos, restrições hidráulicas e por fim os demais dados que compõe toda a informação referente a atual revisão.

Os principais fatores que influenciaram na elevação do CMO nos subsistemas Sudeste/Centro-Oeste, Sul e Norte, foram a redução das vazões, alteração dos CVUs de algumas usinas termoelétricas e o adiamento do retorno da unidade geradora de Angra II.

Figura 3 – Análise da variação do CMO nos subsistemas SE/CO, Sul

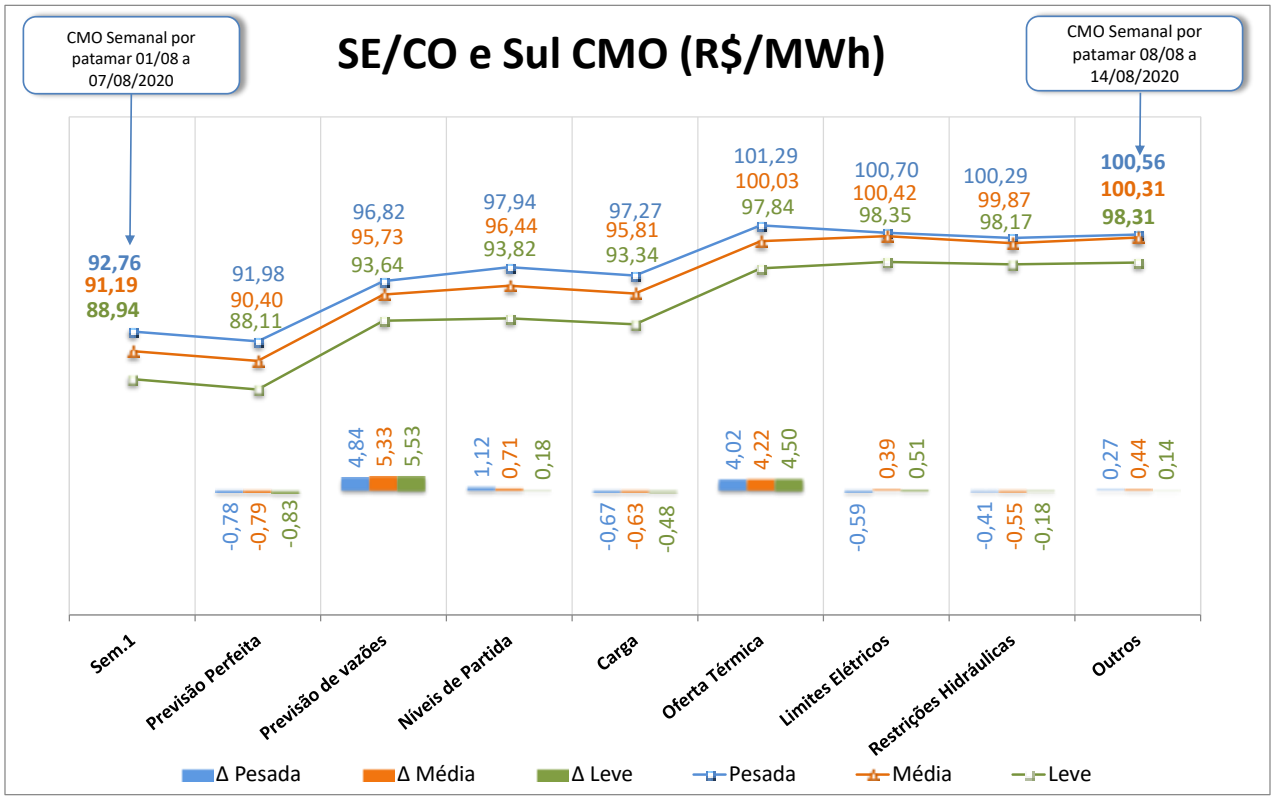

O conteúdo desta publicação foi produzido pelo ONS com base em dados e informações de conhecimento público. É de responsabilidade exclusiva dos agentes e demais interessados a obtenção de outros dados e informações, a realização de análises, estudos e avaliações para fins de tomada de decisões, definição de estratégias de atuação, assunção de compromissos e obrigações e quaisquer outras finalidades, em qualquer tempo e sob qualquer condição. É proibida a reprodução ou utilização total ou parcial do presente sem a identificação da fonte.

No subsistema NE já era previsto a elevação do CMO para essa semana e esse fator foi reforçado/corroborado pela atualização da previsão de vazões.

Figura 4 – Análise da variação do CMO nos subsistemas Nordeste

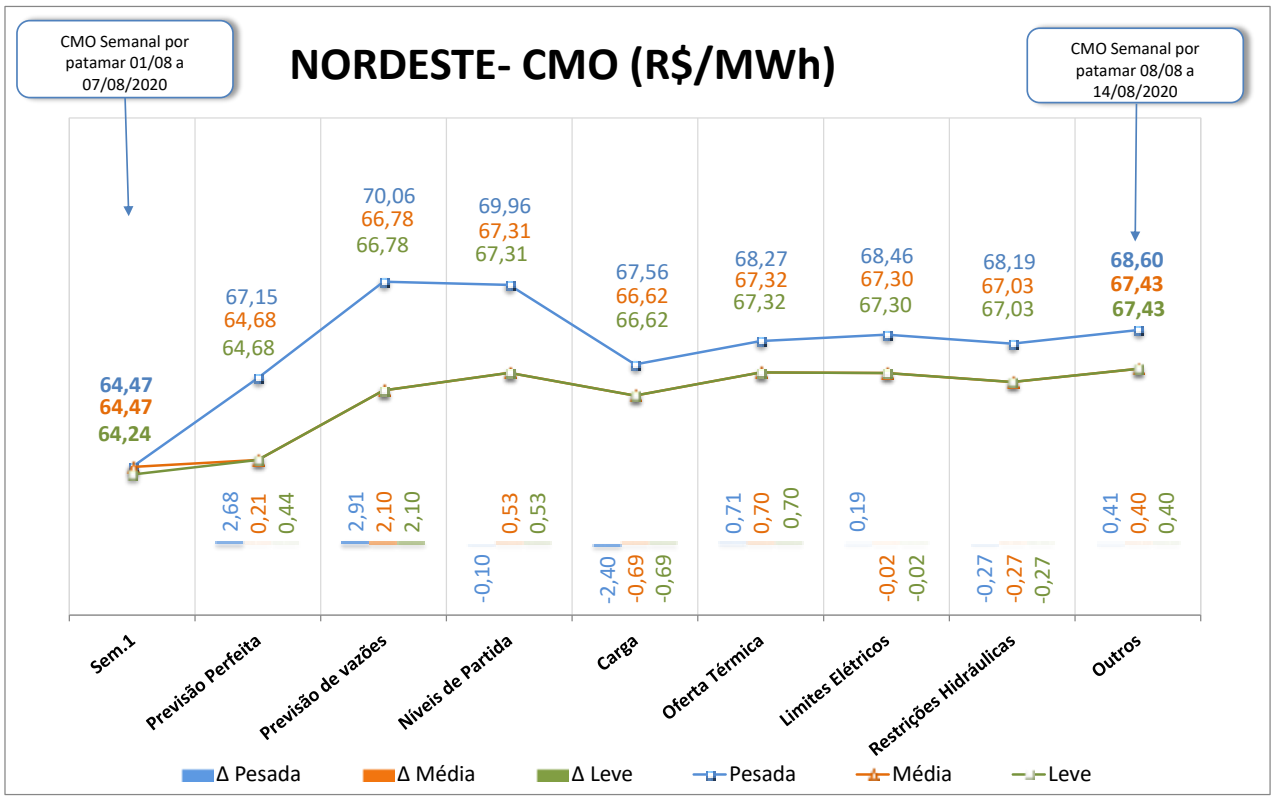

Figura 5 – Análise da variação do CMO nos subsistemas Norte

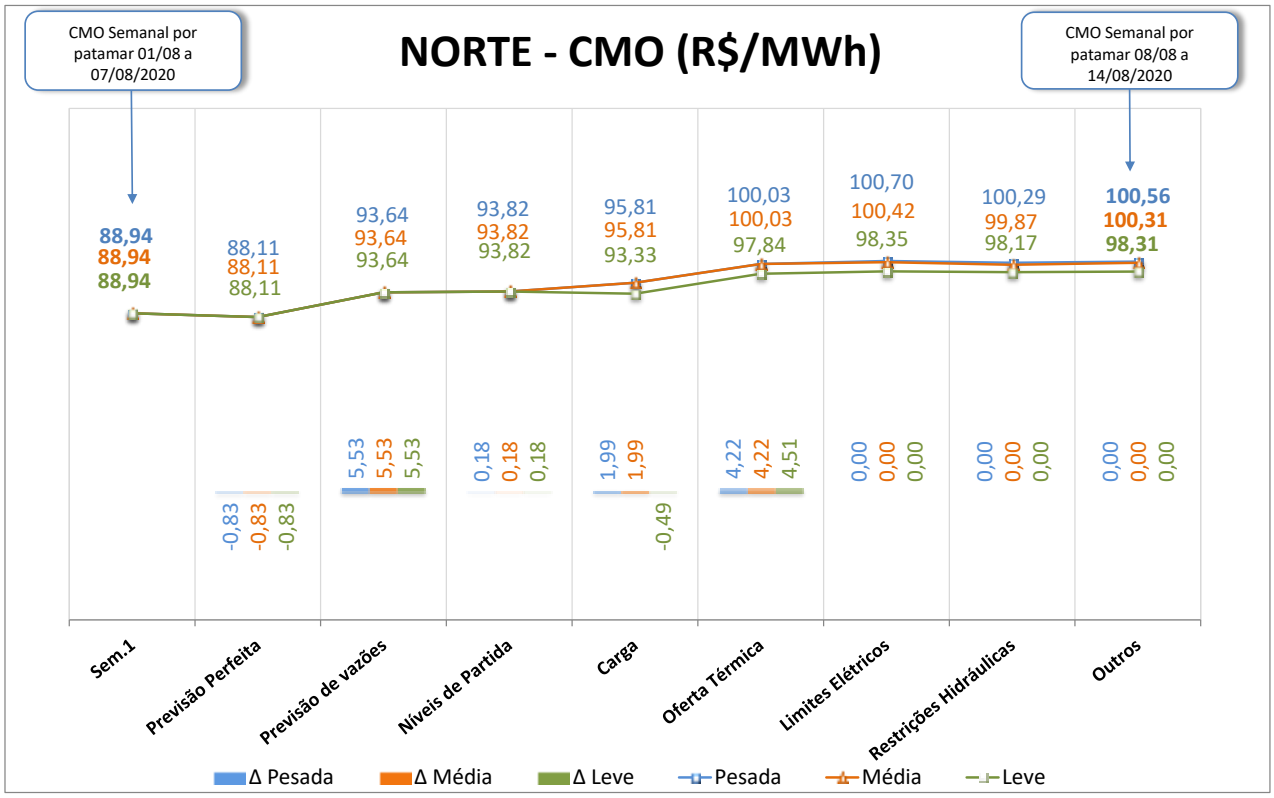

O conteúdo desta publicação foi produzido pelo ONS com base em dados e informações de conhecimento público. É de responsabilidade exclusiva dos agentes e demais interessados a obtenção de outros dados e informações, a realização de análises, estudos e avaliações para fins de tomada de decisões, definição de estratégias de atuação, assunção de compromissos e obrigações e quaisquer outras finalidades, em qualquer tempo e sob qualquer condição. É proibida a reprodução ou utilização total ou parcial do presente sem a identificação da fonte.

7. GERAÇÃO TÉRMICA

A Figura 6 apresenta, para cada subsistema, o despacho térmico por modalidade, para a próxima semana operativa.

Figura 6 – Geração térmica para a próxima semana operativa

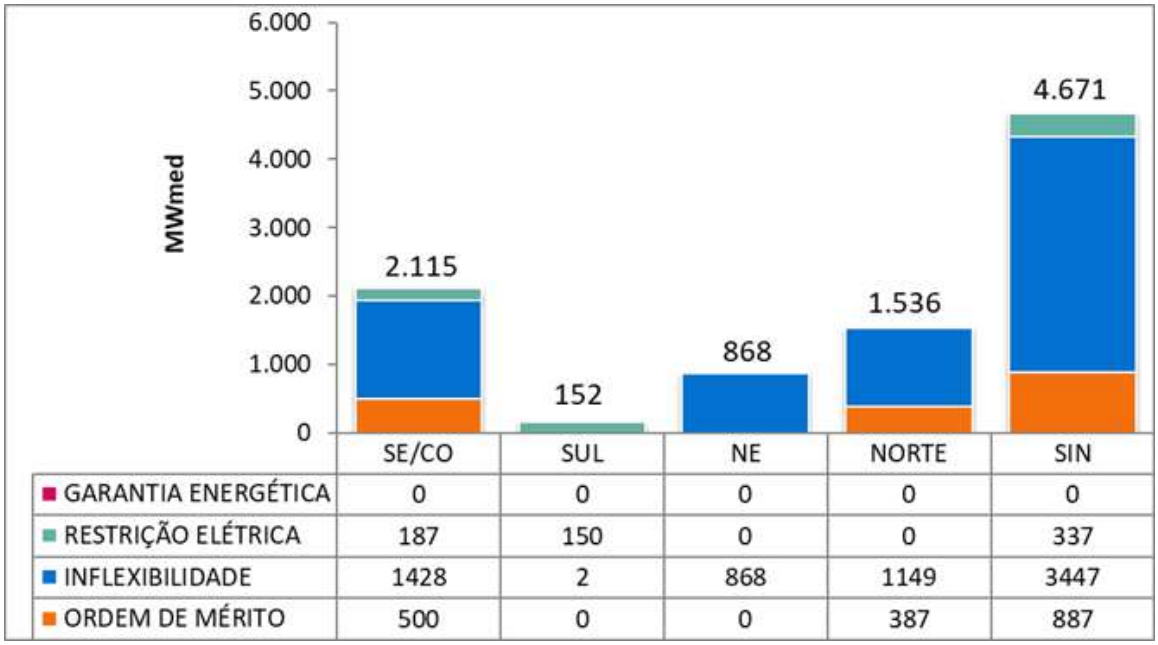

Na tabela abaixo segue a Indicação de despacho antecipado por ordem de mérito de custo para a semana de 10/10/2020 a 16/10/2020.

Tabela 4 – UTEs com contrato de combustível GNL

UTE			Benefício (R$/MWh)		
Nome	Cod	CVU (R$/MWh)	Carga Pesada	Carga Média	Carga Leve
SANTA CRUZ	86	127,52	75,89 (2)	75,89 (2)	75,88 (2)
LUIZORMELO	15	189,33	75,89 (2)	75,89 (2)	75,88 (2)
PSERGIPE I	224	203,10	74,72 (2)	70,57 (2)	70,57 (2)

(1) Comandado o despacho antecipado por ordem de mérito de custo nesse patamar

(2) NÃO foi comandado o despacho antecipado por ordem de mérito de custo nesse patamar

Apesar da UTE Luiz O. R. Melo não estar despachada por ordem de mérito, há necessidade do despacho de, pelo menos, 204 MW dessa usina para reduzir o risco de corte de carga na região de Governador Valadares e na região Norte do Espírito Santo. Desta forma, a UTE Luiz O. R. Melo deverá ser despachada por razão elétrica, na referida semana, em 204 MW.

O conteúdo desta publicação foi produzido pelo ONS com base em dados e informações de conhecimento público. É de responsabilidade exclusiva dos agentes e demais interessados a obtenção de outros dados e informações, a realização de análises, estudos e avaliações para fins de tomada de decisões, definição de estratégias de atuação, assunção de compromissos e obrigações e quaisquer outras finalidades, em qualquer tempo e sob qualquer condição. É proibida a reprodução ou utilização total ou parcial do presente sem a identificação da fonte.

8. IMPORTAÇÃO DE ENERGIA DA REPÚBLICA ORIENTAL DO URUGUAI

8.1. República Oriental do Uruguai

Para a próxima semana operativa, foram declaradas as seguintes ofertas de importação de energia da República Oriental do Uruguai para o Sistema Interligado Nacional - SIN através das conversoras de Rivera (70 MW) e Melo (500 MW).

Conforme declaração dos agentes a Conversora de Rivera estará indisponível no dia 11/08/2020 das 08:00 às 18:00 horas e a Conversora de Melo estará indisponível no dia 13/08/2020 das 05:00 às 07:00 horas.

- **Eletrobras**

Tabela 5 – Energia Ofertada para Importação

	Oferta de Energia para a Semana de 8/8 a 14/8 (MWmed)			
	Bloco 1	Bloco 2	Bloco 3	Total
Carga Pesada	70,0	60,0	190,0	320,0
Carga Média	70,0	60,0	190,0	320,0
Carga Leve	70,0	60,0	190,0	320,0
CVU (R$/MWh)	199,30	317,72	710,75	

- **Enel**

Tabela 6 – Energia Ofertada para Importação

	Oferta de Energia para a Semana de 8/8 a 14/8 (MWmed)		
	Bloco 1	Bloco 2	Total
Carga Pesada	60,0	190,0	250,0
Carga Média	60,0	190,0	250,0
Carga Leve	60,0	190,0	250,0
CVU (R$/MWh)	324,59	724,97	

8.2. República da Argentina

Para a semana operativa de 08/08 a 14/08/2020, não houve oferta de importação de energia da República da Argentina.

Nota: Detalhes sobre a importação de energia vide Portaria Nº 339, de 15 de Agosto de 2018 disponível em: http://pesquisa.in.gov.br/imprensa/jsp/visualiza/index.jsp?data=17/08/2018&jornal=515&pagina=60&totalArquivos=136

9. ESTIMATIVA DE ENCARGOS OPERATIVOS

A tabela a seguir apresenta a expectativa do custo de despacho térmico por restrição elétrica para esta semana operativa.

Tabela 7 – Expectativa de custo de despacho térmico por Restrição Elétrica

UTE Potência Instalada (MW)	CVU (R$/MWh)	Geração (MWmed)			ESS ELÉTRICO
		Carga Pesada	Carga Média	Carga Leve	
LUIZORMELO (204)	R$ 189,33	187,0	187,0	187,0	**R$ 2.821.897,32**
TOTAL SE/CO					R$ 2.821.897,32

O conteúdo desta publicação foi produzido pelo ONS com base em dados e informações de conhecimento público. É de responsabilidade exclusiva dos agentes e demais interessados a obtenção de outros dados e informações, a realização de análises, estudos e avaliações para fins de tomada de decisões, definição de estratégias de atuação, assunção de compromissos e obrigações e quaisquer outras finalidades, em qualquer tempo e sob qualquer condição. É proibida a reprodução ou utilização total ou parcial do presente sem a identificação da fonte.

10. ARMAZENAMENTOS OPERATIVOS

Para uma melhor avaliação de diversos cenários hidrometeorológicos, notadamente, aqueles de curto prazo e suas influências nas previsões de vazões nos subsistemas, os resultados desta revisão do PMO contemplam cenários de afluências visando melhor representar a ocorrência de precipitação e, consequentemente, seus efeitos sobre as afluências e armazenamentos.

Além dos resultados associados ao valor esperado das previsões de afluências, as simulações operativas também foram realizadas com os limites superior e inferior das previsões de afluências. Apresentamos a seguir os resultados obtidos com a aplicação dos diferentes cenários de afluência.

Tabela 8 – Previsão de ENA dos cenários de sensibilidade

Subsistema	ENERGIAS NATURAIS AFLUENTES					
	Previsão Mensal					
	LI		VE		LS	
	(MWmed)	%MLT	(MWmed)	%MLT	(MWmed)	%MLT
Sudeste	13.656	**66**	15.057	**73**	16.451	**80**
Sul	2.860	**28**	5.669	**56**	9.060	**90**
Nordeste	2.143	**64**	2.248	**67**	2.351	**70**
Norte	2.290	**71**	2.442	**76**	2.593	**80**

Tabela 9 – Previsão de %EARmáx para o final do mês

Subsistema	% EARmáx 7/8	% EARmáx - 31/8		
	NÍVEL INICIAL	NÍVEL PMO		
	VE	LI	VE	LS
Sudeste	46,5	41,2	42,5	43,4
Sul	55,9	37,5	42,0	51,3
Nordeste	80,4	70,8	71,0	71,3
Norte	78,4	69,0	69,3	69,4

O conteúdo desta publicação foi produzido pelo ONS com base em dados e informações de conhecimento público. É de responsabilidade exclusiva dos agentes e demais interessados a obtenção de outros dados e informações, a realização de análises, estudos e avaliações para fins de tomada de decisões, definição de estratégias de atuação, assunção de compromissos e obrigações e quaisquer outras finalidades, em qualquer tempo e sob qualquer condição. É proibida a reprodução ou utilização total ou parcial do presente sem a identificação da fonte.

11. RESERVATÓRIOS EQUIVALENTES DE ENERGIA

A seguir são apresentadas as previsões de Energia Natural Afluente para a próxima semana operativa e para o mês de agosto, bem como as previsões de Energia Armazenada nos Reservatórios Equivalentes de Energia – REE, desta Revisão do PMO.

Tabela 10 – Previsão de ENA por REE

Valor Esperado das Energias Naturais Afluentes				
REE	Previsão Semanal		Previsão Mensal	
	08/08/2020 a 14/08/2020		ago/20	
	(MWmed)	%MLT	(MWmed)	%MLT
Sudeste	1.908	78	1.897	77
Madeira	2.073	87	1.947	81
Teles Pires	540	69	535	69
Itaipu	1.879	72	1.895	72
Paraná	8.009	76	7.950	76
Paranapanema	768	41	807	43
Sul	3.167	53	4.095	68
Iguaçu	1.339	33	1.575	38
Nordeste	2.306	69	2.248	67
Norte	1.285	70	1.234	67
Belo Monte	675	100	599	89
Manaus	676	96	640	91

Tabela 11 – Previsão de %EARmáx por REE

% Energia Armazenável Máxima		
REE	Previsão Semanal	Previsão Mensal
	14-ago	31-ago
	(%EARmáx)	(%EARmáx)
Sudeste	41,1	38,1
Madeira	50,6	35,2
Teles Pires	11,2	10,1
Itaipu	29,9	85,1
Paraná	47,9	44,6
Paranapanema	35,9	35,3
Sul	69,2	63,6
Iguaçu	34,5	22,4
Nordeste	77,8	71,0
Norte	77,5	70,5
Belo Monte	100,0	99,6
Manaus	50,6	44,1

O conteúdo desta publicação foi produzido pelo ONS com base em dados e informações de conhecimento público. É de responsabilidade exclusiva dos agentes e demais interessados a obtenção de outros dados e informações, a realização de análises, estudos e avaliações para fins de tomada de decisões, definição de estratégias de atuação, assunção de compromissos e obrigações e quaisquer outras finalidades, em qualquer tempo e sob qualquer condição. É proibida a reprodução ou utilização total ou parcial do presente sem a identificação da fonte.

12. DESPACHO TÉRMICO POR MODALIDADE, PATAMAR DE CARGA E USINA

Nas tabelas abaixo, a diferenciação entre geração por inflexibilidade e por ordem de mérito tem caráter informativo, com o objetivo de detalhar a informação de inflexibilidade enviada pelos respectivos agentes para esta revisão do PMO. Ressalta-se que nas etapas de Programação Diária e Tempo Real, o montante despachado nas usinas termelétricas indicadas por ordem de mérito é plenamente intitulado como ordem de mérito.

REGIÃO SUDESTE/CENTRO-OESTE

Combustível	Combustível	CVU (R$/MWh)	Inflexibilidade			Ordem de Mérito			Total Mérito e INFL.			Razão Elétrica			Total UTE		
			P	M	L	P	M	L	P	M	L	P	M	L	P	M	L
ATLAN_CSA (255)	Resíduos	0,00	166,0	166,0	166,0				166,0	166,0	166,0				166,0	166,0	166,0
ANGRA 2 (1350)	Nuclear	20,12				0,0	0,0	0,0	0,0	0,0	0,0				0,0	0,0	0,0
ANGRA 1 (640)	Nuclear	31,17	640,0	640,0	640,0	0,0	0,0	0,0	640,0	640,0	640,0				640,0	640,0	640,0
NORTEFLU 1 (400)	Gás	83,15				400,0	400,0	400,0	400,0	400,0	400,0				400,0	400,0	400,0
NORTEFLU 2 (100)	Gás	94,21				100,0	100,0	100,0	100,0	100,0	100,0				100,0	100,0	100,0
BAIXADA FL (530)	Gás	112,83															
UTE STA VI (41)	Biomassa	116,91	13,0	13,0	13,0				13,0	13,0	13,0				13,0	13,0	13,0
SANTA CRUZ (500)	GNL	127,52															
NORTEFLU 3 (200)	Gás	180,11															
LUIZORMELO (204)	GNL	189,33										187,0	187,0	187,0	187,0	187,0	187,0
ATLANTICO (235)	Resíduos	192,23	218,7	218,7	218,7				218,7	218,7	218,7				218,7	218,7	218,7
T.LAGOAS (350)	Gás	224,29															
TERMORIO (1036)	Gás	267,47	285,0	285,0	285,0				285,0	285,0	285,0				285,0	285,0	285,0
JUIZ DE FO (87)	Gás	283,74															
ST.CRUZ 34 (436)	Óleo	310,41															
CUBATAO (216)	Gás	333,31	105,0	105,0	105,0				105,0	105,0	105,0				105,0	105,0	105,0
SEROPEDICA (386)	Gás	343,38															
IBIRITE (226)	Gás	346,37															
NORTEFLU 4 (127)	Gás	369,80															
CUIABA CC (529)	Gás	377,54															
PIRAT.12 O (200)	Gás	470,34															
NPIRATINGA (572)	Gás	548,04															
VIANA (175)	Óleo	599,66															
T.MACAE (929)	Gás	611,82															
TNORTE 2 (340)	Óleo	910,86															
PALMEIR_GO (176)	Diesel	924,72															
IGARAPE (131)	Óleo	939,55															
CAMPOS (25)	Gás	978,10															
DAIA (44)	Diesel	1178,36															
GOIANIA 2 (140)	Diesel	1235,54															
XAVANTES (54)	Diesel	1694,77															
TOTAL SE/CO (10634)			1427,70	1427,70	1427,70	500,0	500,0	500,0	1927,7	1927,7	1927,7	187,0	187,0	187,0	2114,7	2114,7	2114,7

REGIÃO SUL

Combustível	Combustível	CVU (R$/MWh)	Inflexibilidade			Ordem de Mérito			Total Mérito e INFL.			Razão Elétrica			Total UTE		
			P	M	L	P	M	L	P	M	L	P	M	L	P	M	L
PAMPA SUL (345)	Carvão	67,12				0,0	0,0	0,0	0,0	0,0	0,0				0,0	0,0	0,0
SAO SEPE (8)	Biomassa	84,44				0,0	0,0	0,0	0,0	0,0	0,0				0,0	0,0	0,0
CANDIOTA_3 (350)	Carvão	86,37				0,0	0,0	0,0	0,0	0,0	0,0				0,0	0,0	0,0
J.LACER. C (363)	Carvão	206,84															
J.LACER. B (262)	Carvão	244,14										80,0	80,0	80,0	80,0	80,0	80,0
J.LAC. A2 (132)	Carvão	245,21										70,0	70,0	70,0	70,0	70,0	70,0
J.LAC. A1 (100)	Carvão	270,48															
URUGUAIANA (640)	Gás	278,48															
MADEIRA (4)	Biomassa	308,66	2,0	2,0	2,0				2,0	2,0	2,0				2,0	2,0	2,0
FIGUEIRA (20)	Carvão	475,68															
ARAUCARIA (484)	Gás	614,75															
CANOAS (249)	Diesel	698,14															
TOTAL SUL (2957)			2,00	2,00	2,00	0,0	0,0	0,0	2,0	2,0	2,0	150,0	150,0	150,0	152,0	152,0	152,0

O conteúdo desta publicação foi produzido pelo ONS com base em dados e informações de conhecimento público. É de responsabilidade exclusiva dos agentes e demais interessados a obtenção de outros dados e informações, a realização de análises, estudos e avaliações para fins de tomada de decisões, definição de estratégias de atuação, assunção de compromissos e obrigações e quaisquer outras finalidades, em qualquer tempo e sob qualquer condição. É proibida a reprodução ou utilização total ou parcial do presente sem a identificação da fonte.

REGIÃO NORDESTE

Combustível	Combustível	CVU (R$/MWh)	Inflexibilidade			Ordem de Mérito			Total Mérito e INFL.			Razão Elétrica			Total UTE		
			P	M	L	P	M	L	P	M	L	P	M	L	P	M	L
P.PECEM1 (720)	Carvão	156,66															
PROSPERIDA (28)	Gás	159,37	3,6	2,6	2,6				3,6	2,6	2,6				3,6	2,6	2,6
P.PECEM2 (365)	Carvão	167,62															
T.BAHIA (186)	Gás	177,50	150,0	150,0	150,0				150,0	150,0	150,0				150,0	150,0	150,0
TERMOPE (533)	Gás	177,66	532,7	532,7	532,7				532,7	532,7	532,7				532,7	532,7	532,7
FORTALEZA (327)	Gás	180,57															
VALE ACU (368)	Gás	182,56	155,0	155,0	155,0				155,0	155,0	155,0				155,0	155,0	155,0
PSERGIPE I (1516)	GNL	203,10															
T.CAMACARI (120)	Gás	345,02															
TERMOCEARA (223)	Gás	370,82															
PERNAMBU_3 (201)	Óleo	446,42															
MARACANAU (168)	Óleo	508,56															
SYKUE I (30)	Biomassa	510,12	27,0	27,0	27,0				27,0	27,0	27,0				27,0	27,0	27,0
CAMPINA_GR (169)	Óleo	528,93															
TERMOCABO (50)	Óleo	592,51															
TERMONE (171)	Óleo	597,99															
TERMOPB (171)	Óleo	597,99															
SUAPE II (381)	Óleo	601,60															
GLOBAL I (149)	Óleo	680,64															
GLOBAL II (149)	Óleo	680,64															
BAHIA_1 (31)	Óleo	730,86															
ALTOS (13)	Diesel	1023,94															
ARACATI (11)	Diesel	1023,94															
BATURITE (11)	Diesel	1023,94															
C.MAIOR (13)	Diesel	1023,94															
CAUCAIA (15)	Diesel	1023,94															
CRATO (13)	Diesel	1023,94															
IGUATU (15)	Diesel	1023,94															
JUAZEIRO N (15)	Diesel	1023,94															
MARAMBAIA (13)	Diesel	1023,94															
NAZARIA (13)	Diesel	1023,94															
PECEM (15)	Diesel	1023,94															
AREMBEPE (150)	Óleo	1167,07															
MURICY (147)	Óleo	1167,07															
POTIGUAR_3 (66)	Diesel	1222,81															
POTIGUAR (53)	Diesel	1222,82															
PETROLINA (136)	Óleo	1280,44															
PAU FERRO (94)	Diesel	1379,18															
TERMOMANAU (143)	Diesel	1379,18															
TOTAL NE (6992)			868,30	867,30	867,30	0,0	0,0	0,0	868,3	867,3	867,3	0,0	0,0	0,0	868,3	867,3	867,3

REGIÃO NORTE

Combustível	Combustível	CVU (R$/MWh)	Inflexibilidade			Ordem de Mérito			Total Mérito e INFL.			Razão Elétrica			Total UTE		
			P	M	L	P	M	L	P	M	L	P	M	L	P	M	L
C. ROCHA (85)	Gás	0,00	65,0	65,0	65,0				65,0	65,0	65,0				65,0	65,0	65,0
JARAQUI (75)	Gás	0,00	63,0	63,0	63,0				63,0	63,0	63,0				63,0	63,0	63,0
MANAUARA (67)	Gás	0,00	64,5	64,5	64,5				64,5	64,5	64,5				64,5	64,5	64,5
PONTA NEGR (66)	Gás	0,00	64,0	64,0	64,0				64,0	64,0	64,0				64,0	64,0	64,0
TAMBAQUI (93)	Gás	0,00	63,0	63,0	63,0				63,0	63,0	63,0				63,0	63,0	63,0
APARECIDA (166)	Gás	67,79	75,0	75,0	75,0	39,4	43,0	47,3	114,4	118,0	122,3				114,4	118,0	122,3
UTE MAUA 3 (591)	Gás	67,79	264,0	264,0	264,0	326,8	326,8	326,8	590,8	590,8	590,8				590,8	590,8	590,8
MARANHAO3 (519)	Gás	82,48	490,0	490,0	490,0	4,8	25,3	22,7	494,8	515,3	512,7				494,8	515,3	512,7
MARANHAO V (338)	Gás	119,11															
MARANHAOIV (338)	Gás	119,11															
PARNAIB_IV (56)	Gás	151,69															
P. ITAQUI (360)	Carvão	162,14															
N.VENECIA2 (270)	Gás	223,51															
GERAMAR1 (166)	Óleo	599,65															
GERAMAR2 (166)	Óleo	599,65															
TOTAL NORTE (3356)			1148,5	1148,5	1148,5	371,0	395,1	396,8	1519,5	1543,6	1545,3	0,0	0,0	0,0	1519,5	1543,6	1545,3

O conteúdo desta publicação foi produzido pelo ONS com base em dados e informações de conhecimento público. É de responsabilidade exclusiva dos agentes e demais interessados a obtenção de outros dados e informações, a realização de análises, estudos e avaliações para fins de tomada de decisões, definição de estratégias de atuação, assunção de compromissos e obrigações e quaisquer outras finalidades, em qualquer tempo e sob qualquer condição. É proibida a reprodução ou utilização total ou parcial do presente sem a identificação da fonte.