1. APRESENTAÇÃO

No mês de setembro os maiores totais de precipitação foram observados nas bacias dos rios Jacuí e Uruguai. Apesar da ocorrência de precipitação nessas bacias, os valores observados não foram suficientes para ultrapassarem a média histórica. Além disso, também houve chuva fraca isolada nas bacias dos rios Paranapanema, Tietê, Grande, Paranaíba, Tocantins, no alto São Francisco e na calha principal do Paraná.

Na semana de 26/09 a 02/10/2020 deve ocorrer fraca à moderada na bacia do rio Jacuí, em pontos isolados do Uruguai e precipitação de intensidade fraca no Iguaçu. As bacias hidrográficas da região Norte devem apresentar pancadas de chuva em pontos isolados.

Para a semana operativa de 26/09 a 02/10/2020, houve oferta de energia da República Oriental do Uruguai e da República da Argentina. De acordo com o Art. 2º da Portaria MME nº 339, de 15 de agosto de 2018, as ofertas para importação de energia não foram consideradas na elaboração do PMO.

Os valores médios semanais do Custo Marginal de Operação – CMO dos subsistemas do SIN sofreram as seguintes alterações em relação à semana anterior:

- SE/CO: de R$ 98,30/MWh para R$ 168,74/MWh
- Sul: de R$ 98,30/MWh para R$ 168,74/MWh
- Nordeste: de R$ 67,41/MWh para R$ 159,18/MWh
- Norte: de R$ 98,30/MWh para R$ 168,74/MWh

Desde o dia 01/01/2020, o despacho por ordem de mérito é indicado diariamente pelos resultados do modelo DESSEM. Assim, o despacho por ordem de mérito semanal, conforme publicado nesse documento, tem caráter apenas informativo.

2. NOTÍCIAS

Nos dias 29 e 30 de outubro será realizada a reunião de elaboração do PMO Novembro de 2020, com transmissão ao vivo através do site do ONS.

Como medida adicional de prevenção ao Coronavírus, o ONS informa que está suspensa, temporariamente, a participação presencial nas reuniões.

3. INFORMAÇÕES PARA ESTUDOS ENERGÉTICOS DE MÉDIO PRAZO - CONSTRUÇÃO DA FUNÇÃO DE CUSTO FUTURO

A atualização de dados para os estudos energéticos de médio prazo é realizada mensalmente quando da elaboração do PMO, tendo por base as informações fornecidas pela ANEEL, MME, EPE, CCEE e Agentes, além de diversas áreas do ONS.

O conteúdo desta publicação foi produzido pelo ONS com base em dados e informações de conhecimento público. É de responsabilidade exclusiva dos agentes e demais interessados a obtenção de outros dados e informações, a realização de análises, estudos e avaliações para fins de tomada de decisões, definição de estratégias de atuação, assunção de compromissos e obrigações e quaisquer outras finalidades, em qualquer tempo e sob qualquer condição. É proibida a reprodução ou utilização total ou parcial do presente sem a identificação da fonte.

3.1. ATUALIZAÇÃO DAS INFORMAÇÕES ESTRUTURAIS

3.1.1. Oferta

Nas **Figura 1**, **Figura 2** e **Figura 3**, a seguir, são apresentadas as evoluções da oferta hidroelétrica, termoelétrica e da disponibilidade das usinas não simuladas individualmente, respectivamente, em comparação ao PMO de setembro/2020, identificando eventuais atrasos ou antecipações de cronograma feitos na reunião de acompanhamento do Departamento de Monitoramento do Setor Elétrico – DMSE/MME, realizada em 17/09/2020.

Figura 1 - Evolução da potência instalada das UHEs

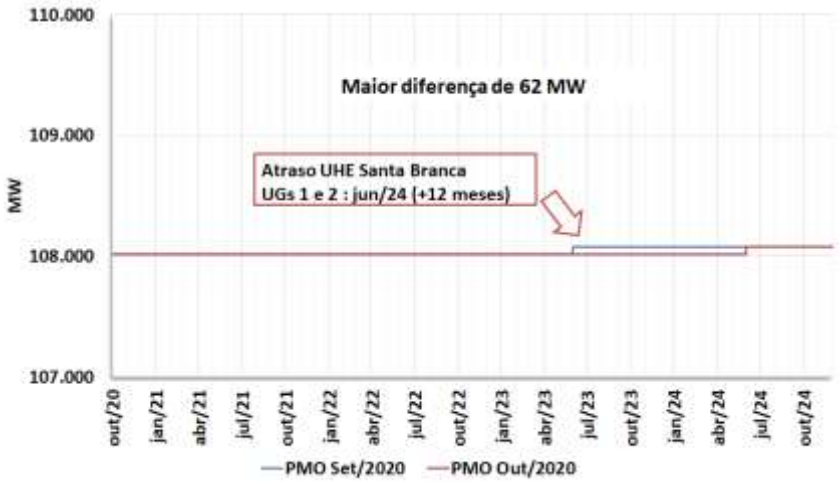

Figura 2 - Evolução da potência instalada das UTEs

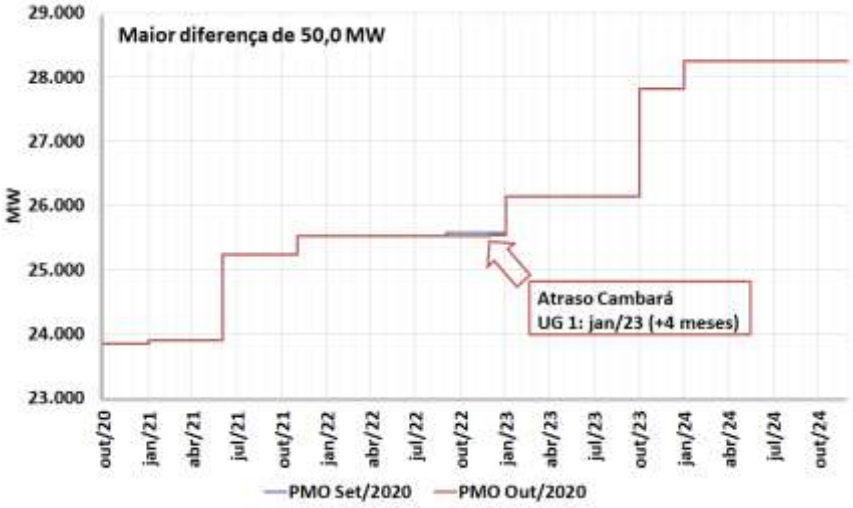

O conteúdo desta publicação foi produzido pelo ONS com base em dados e informações de conhecimento público. É de responsabilidade exclusiva dos agentes e demais interessados a obtenção de outros dados e informações, a realização de análises, estudos e avaliações para fins de tomada de decisões, definição de estratégias de atuação, assunção de compromissos e obrigações e quaisquer outras finalidades, em qualquer tempo e sob qualquer condição. É proibida a reprodução ou utilização total ou parcial do presente sem a identificação da fonte.

Figura 3 - Evolução da disponibilidade das usinas não simuladas

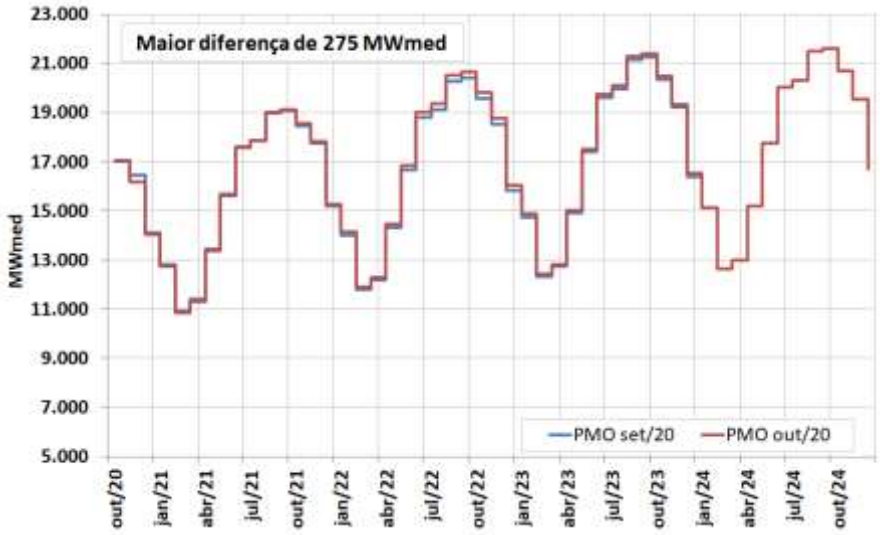

3.1.2. Armazenamentos Iniciais

Na **Figura 4**, a seguir, são apresentados os armazenamentos iniciais equivalentes por subsistema, considerados nos modelos de otimização para a elaboração do PMO de outubro/2020, comparados com os do PMO de setembro/2020.

Figura 4 - Energia armazenada inicial em setembro/20 e outubro/20 – [% EARmáx]

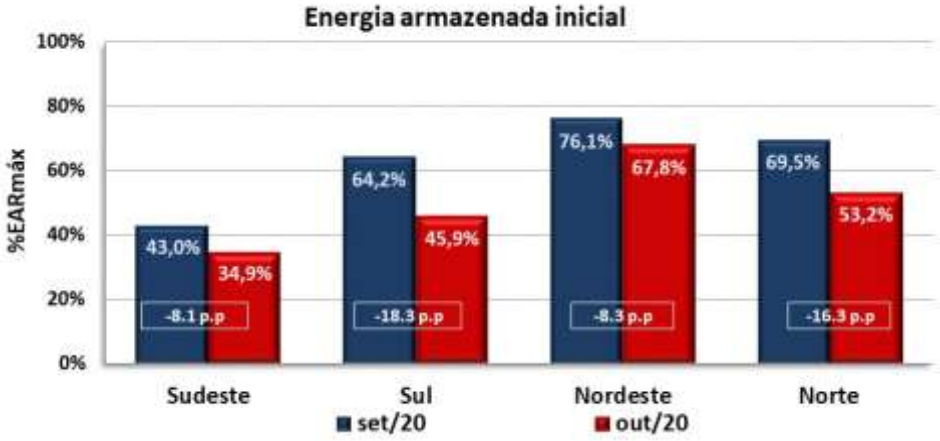

3.1.3. Tendência Hidrológica

Na **Tabela 1**, a seguir, são apresentadas as tendências hidrológicas consideradas pelo modelo NEWAVE para o PMO de outubro/2020, comparadas com o PMO de setembro/2020.

O conteúdo desta publicação foi produzido pelo ONS com base em dados e informações de conhecimento público. É de responsabilidade exclusiva dos agentes e demais interessados a obtenção de outros dados e informações, a realização de análises, estudos e avaliações para fins de tomada de decisões, definição de estratégias de atuação, assunção de compromissos e obrigações e quaisquer outras finalidades, em qualquer tempo e sob qualquer condição. É proibida a reprodução ou utilização total ou parcial do presente sem a identificação da fonte.

Tabela 1 – Tendência hidrológica para o PMO de outubro/2020 – NEWAVE [%MLT]

	PMO setembro/2020				PMO outubro/2020			
MÊS	SE/CO	S	NE	N	SE/CO	S	NE	N
mar/20	103	26	100	109				
abr/20	87	16	103	112	87	16	103	112
mai/20	80	20	80	117	80	20	80	117
jun/20	77	68	74	105	77	68	74	105
jul/20	79	121	72	93	79	121	72	93
ago/20	84	97	71	75	85	97	71	77
set/20					68	46	67	67

* ≥100% MLT < 100% MLT

3.2. DEMAIS ATUALIZAÇÕES

Adicionalmente, neste PMO ocorreram os seguintes destaques:

- Horizonte de estudo: outubro de 2020 a dezembro de 2024;
- Cronograma de Obras – Reunião DMSE-G de 17/09/2020. Enchimento do volume morto do reservatório da UHE Santa Branca Tibagi alterado para jan/2024 (mantida a duração de 2 meses), compatível com a postergação da data de tendência das UGs;
- CVUs de UTEs vendedoras em leilão;
- CVUs das UTEs Termopernambuco, NorteFluminense 1, 2, 3 e 4 e Fortaleza, conforme Despachos SRG/ANEEL nº 2.688/2020, 2.689/2020 e 2.732/2020;
- Alteração de restrições operativas para as UHEs A. A. Laydner, Chavantes, P. Cavalo, Salto e Salto Osório, de acordo com os FSAR-H enviados pelo Agentes responsáveis;
- Alteração do Agente responsável pela UHE Monjolinho (de Monel para STATKFRAT), conforme Resolução Autorizativa ANEEL nº 9.094;
- Alteração da potência da UTE Araucária de 484,5 MW para 484,15 MW (UG1: 156,70 MW, UG2: 158,50 MW e UG3: 168,95 MW), conforme Resolução Autorizativa ANEEL nº 966 e retificação do Despacho SFG/ANEEL nº 1.144/2020;
- Aplicação de restrição de geração para a UTE Termoceará, devido a suspensão parcial de operação comercial conforme Despacho SFG/ANEEL nº 2.705/2020. Disponibilidade até dezembro de 2020 compatibilizada com as informações declaradas pelo Agente Petrobras para o curto prazo, considerando restrição de capacidade até 06/12/20, de acordo com intervenção registrada no SGI, Carta INP/PRI/ARX 0207/2020 e Ofício SFG/ANEEL nº 553/2020;
- Restrições de defluências das usinas do Rio São Francisco conforme "Informe Sobre O Planejamento e a Programação da Operação dos Aproveitamentos Hidroelétricos da Bacia do Rio São Francisco no PMO de Outubro de 2020";
- Limites de transmissão entre subsistemas, para os meses de outubro e novembro/2020.

O conteúdo desta publicação foi produzido pelo ONS com base em dados e informações de conhecimento público. É de responsabilidade exclusiva dos agentes e demais interessados a obtenção de outros dados e informações, a realização de análises, estudos e avaliações para fins de tomada de decisões, definição de estratégias de atuação, assunção de compromissos e obrigações e quaisquer outras finalidades, em qualquer tempo e sob qualquer condição. É proibida a reprodução ou utilização total ou parcial do presente sem a identificação da fonte.

4. ANÁLISE DAS CONDIÇÕES HIDROMETEOROLÓGICAS

4.1. PREVISÃO PARA A PRÓXIMA SEMANA

O avanço de duas frentes frias pela região Sul, uma no início da próxima semana e a outra no final, ocasiona chuva fraca à moderada na bacia do rio Jacuí, em pontos isolados do Uruguai e precipitação de intensidade fraca no Iguaçu **(Figura 5)**. As bacias hidrográficas da região Norte apresentam pancadas de chuva em pontos isolados.

Figura 5 - Precipitação acumulada prevista pelo modelo GEFS (CPTEC/INPE) para o período de 26/09 a 02/10/2020

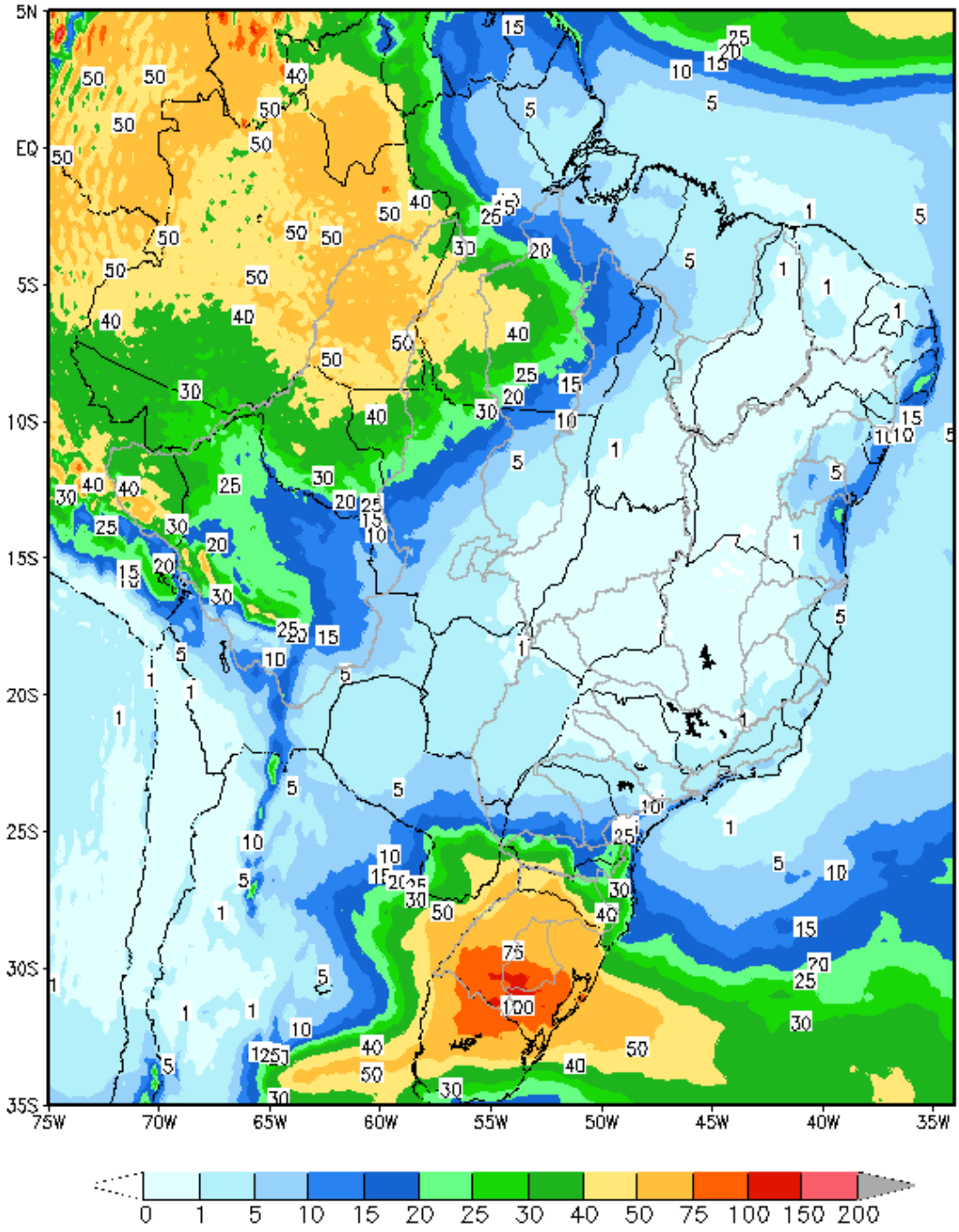

O conteúdo desta publicação foi produzido pelo ONS com base em dados e informações de conhecimento público. É de responsabilidade exclusiva dos agentes e demais interessados a obtenção de outros dados e informações, a realização de análises, estudos e avaliações para fins de tomada de decisões, definição de estratégias de atuação, assunção de compromissos e obrigações e quaisquer outras finalidades, em qualquer tempo e sob qualquer condição. É proibida a reprodução ou utilização total ou parcial do presente sem a identificação da fonte.

Em comparação com os valores estimados para a semana em curso, prevê-se para a próxima semana operativa estabilidade nas afluências do subsistema Sudeste, aumento nas afluências do Sul e leve recessão nas afluências dos subsistemas Nordeste e Norte.

A previsão mensal para outubro indica a ocorrência de afluências abaixo da média histórica para todos os subsistemas.

Tabela 2 – Previsão de ENAs do PMO de outubro/2020

PMO de Outubro/2020 - ENAs previstas				
Subsistema	26/9 a 2/10/2020		Mês de Outubro	
	MWmed	%MLT	MWmed	%MLT
SE/CO	12.185	58	16.111	68
S	5.171	42	8.148	61
NE	1.847	60	1.877	58
N	1.202	52	1.484	62

5. PREVISÃO DE CARGA

Publicações recentes da Fundação Getúlio Vargas – FGV (sondagem do comércio, consumidor e prévia da sondagem da indústria) demonstram uma expectativa de continuidade do processo de retomada das atividades econômicas nos próximos meses. Dessa forma, as previsões consolidadas para o mês de outubro, tomaram como base tal processo de retomada, além das sinalizações meteorológicas para o período.

As sinalizações meteorológicas indicam para todas as regiões ocorrência de temperaturas médias semelhantes as observadas para esse período nos últimos anos.

As taxas de crescimento previstas para o mês de outubro em relação ao mesmo mês de 2019, são de 0,2% no subsistema Sul, 7,2% no subsistema Norte. Para os subsistemas Sudeste/Centro-Oeste e Nordeste são esperadas, respectivamente, variações **negativas** de, 0,6% e 1,4%.

No subsistema Norte o retorno da carga de um consumidor livre da rede básica justifica em parte, a elevada taxa de crescimento observada nesse subsistema.

Tabela 3 – Evolução da carga do PMO de outubro/2020

Subsistema	CARGA SEMANAL (MWmed)						CARGA MENSAL (MWmed)	
	1ª Sem	2ª Sem	3ª Sem	4ª Sem	5ª Sem	6ª Sem	out/20	Var. (%) out/20 -> out/19
Sudeste	41.023	40.762	39.603	40.771	40.844	39.632	40.501	-0,6%
Sul	11.817	11.838	11.368	11.846	11.861	11.266	11.719	0,2%
Nordeste	11.273	11.249	10.959	11.354	11.479	10.996	11.253	-1,4%
Norte	6.086	6.085	5.994	6.093	6.095	5.963	6.064	7,2%
SIN	70.198	69.934	67.925	70.064	70.278	67.858	69.537	0,1%

O conteúdo desta publicação foi produzido pelo ONS com base em dados e informações de conhecimento público. É de responsabilidade exclusiva dos agentes e demais interessados a obtenção de outros dados e informações, a realização de análises, estudos e avaliações para fins de tomada de decisões, definição de estratégias de atuação, assunção de compromissos e obrigações e quaisquer outras finalidades, em qualquer tempo e sob qualquer condição. É proibida a reprodução ou utilização total ou parcial do presente sem a identificação da fonte.

6. PRINCIPAIS RESULTADOS

6.1. CUSTO MARGINAL DE OPERAÇÃO (CMO)

A tabela a seguir apresenta o CMO, por subsistema e patamar de carga para próxima semana operativa.

Tabela 4 – CMO por patamar de carga

Patamares de Carga	CMO (R$/MWh)			
	SE/CO	S	NE	N
Pesada	172,93	172,93	160,86	172,93
Média	171,01	171,01	159,43	171,01
Leve	165,05	165,05	158,02	165,05
Média Semanal	168,74	168,74	159,18	168,74

Na figura a seguir é apresentada a evolução do CMO médio semanal ao longo deste PMO.

Figura 6 – Evolução semanal do CMO

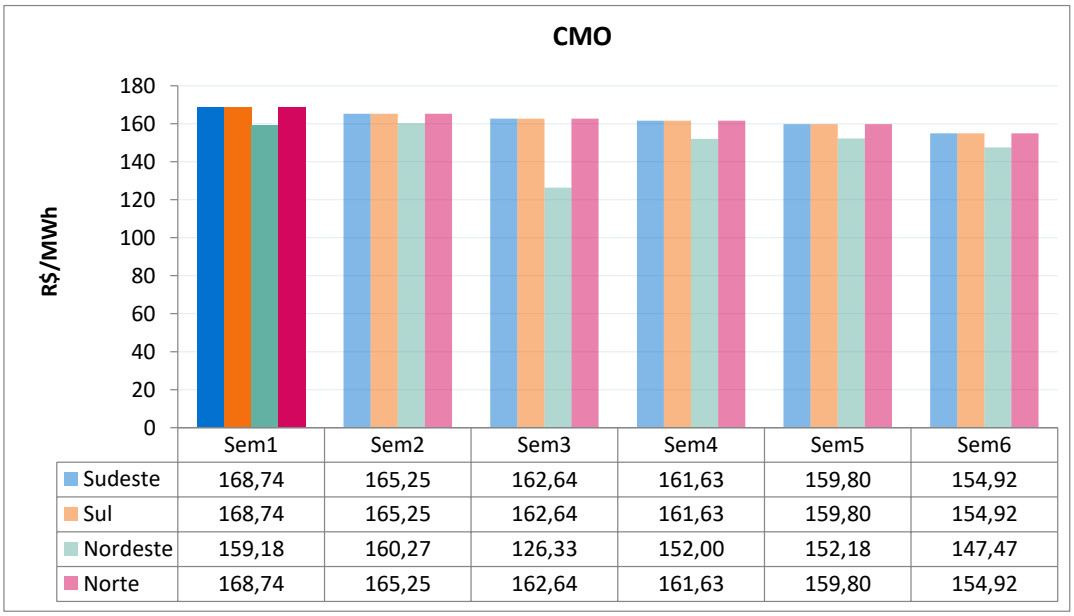

6.2. POLÍTICA DE OPERAÇÃO ENERGÉTICA

Para esta semana operativa, está prevista a seguinte política de intercâmbio de energia entre regiões:

Região SE/CO → Geração dimensionada para fechamento do balanço energético do SIN.

Região Sul → Geração dimensionada de forma a otimizar os recursos desta região.

Região NE → Intercâmbio de energia definido em função dos recursos energéticos da região, buscando-se a máxima exploração, respeitando-se os limites elétricos vigentes para o subsistema.

Região Norte → Geração dimensionada de forma a otimizar os recursos desta região e buscando-se a aderência a curva guia para o armazenamento da UHE Tucuruí.

O conteúdo desta publicação foi produzido pelo ONS com base em dados e informações de conhecimento público. É de responsabilidade exclusiva dos agentes e demais interessados a obtenção de outros dados e informações, a realização de análises, estudos e avaliações para fins de tomada de decisões, definição de estratégias de atuação, assunção de compromissos e obrigações e quaisquer outras finalidades, em qualquer tempo e sob qualquer condição. É proibida a reprodução ou utilização total ou parcial do presente sem a identificação da fonte.

7. ANÁLISE DA VARIAÇÃO SEMANAL DO CMO

Esta análise visa identificar os principais parâmetros cujas atualizações impactaram os CMO deste PMO, em comparação com os valores obtidos na última revisão.

Foram realizados 9 estudos, onde caso inicial foi construído com base nos dados preliminares para este PMO, porém ainda utilizando a Função de Custo Futuro elaborada no PMO anterior. Neste primeiro estudo foram retiradas as restrições de limites conjunturais e a partida dos reservatórios foi estimada conforme indicado para esta semana na última revisão do PMO anterior.

O segundo estudo foi realizado com os dados do caso inicial sendo substituída Função de Custo Futuro anterior pela nova Função elaborada para este PMO e posteriormente a previsão de vazões foram atualizadas.

A partir do conjunto de dados do terceiro estudo foram elaborados os demais casos onde foram atualizados, sequencialmente, as seguintes informações: partida dos reservatórios, previsão de carga, disponibilidade das usinas térmicas e hidráulicas, limites elétricos, restrições hidráulicas e por fim os demais dados que compõe toda a informação referente a atual revisão.

Para todos o subsistemas do SIN já era previsto a elevação do CMO no estudo realizado com os dados preliminares para este PMO. A atualização da Função de Custo Futuro, níveis de partida e previsão de carga também corroboraram no comportamento do CMO nesse sentido.

Figura 7 – Análise da variação do CMO nos subsistemas SE/CO, Sul e Norte

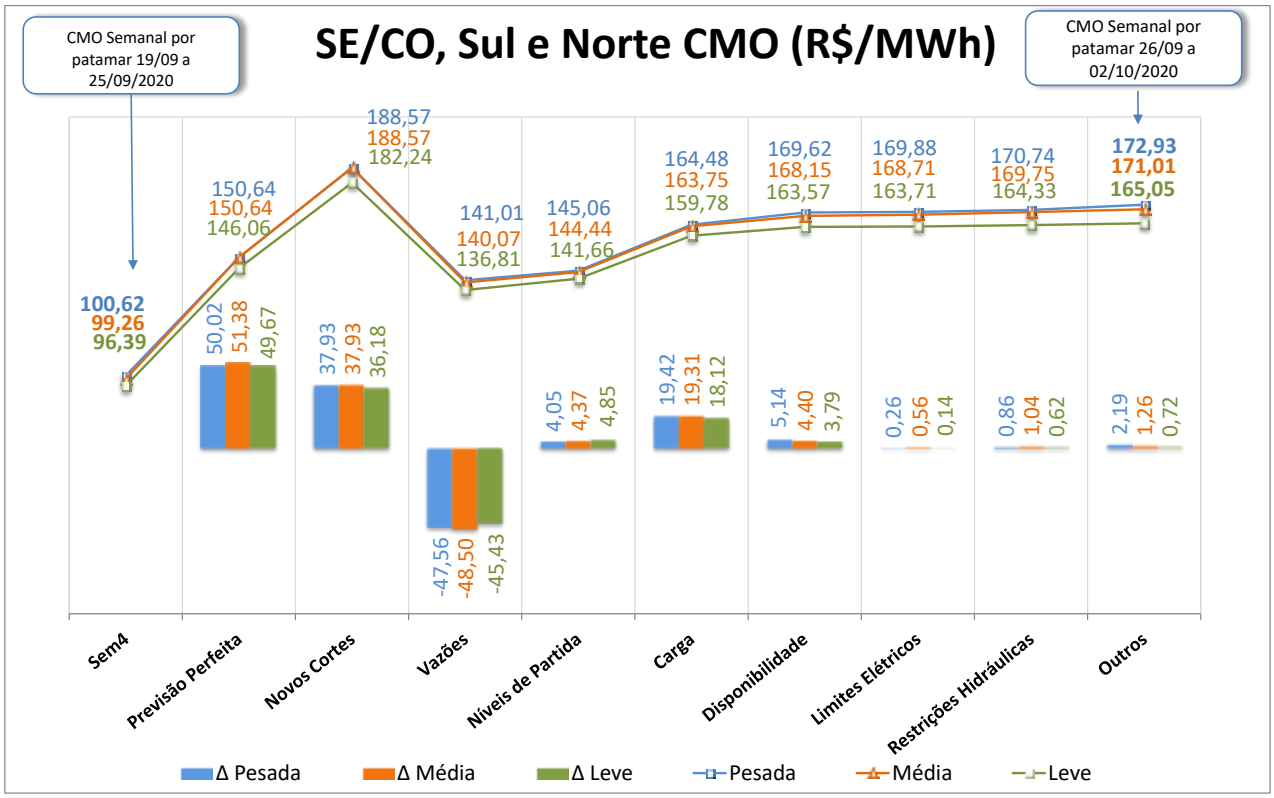

O conteúdo desta publicação foi produzido pelo ONS com base em dados e informações de conhecimento público. É de responsabilidade exclusiva dos agentes e demais interessados a obtenção de outros dados e informações, a realização de análises, estudos e avaliações para fins de tomada de decisões, definição de estratégias de atuação, assunção de compromissos e obrigações e quaisquer outras finalidades, em qualquer tempo e sob qualquer condição. É proibida a reprodução ou utilização total ou parcial do presente sem a identificação da fonte.

Figura 8 – Análise da variação do CMO no subsistema Nordeste

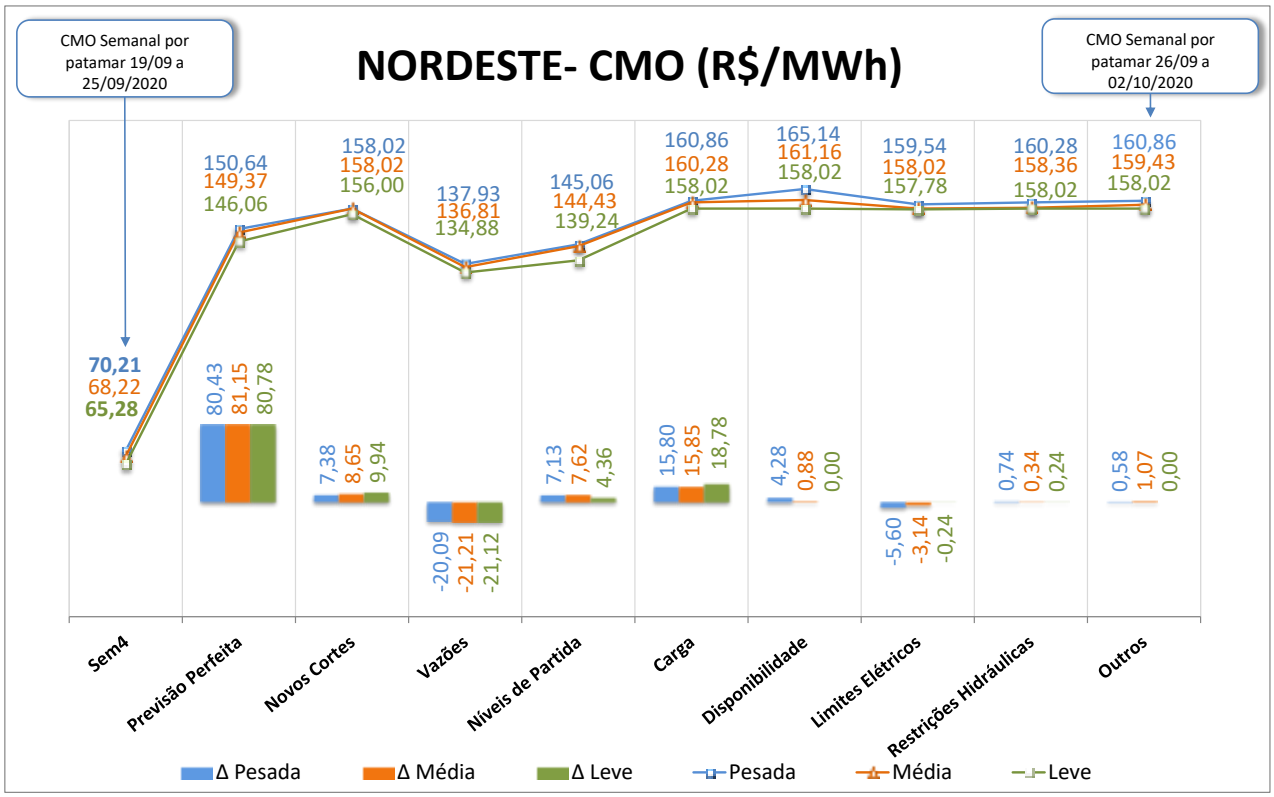

8. GERAÇÃO TÉRMICA

A **Figura 9** apresenta, para cada subsistema, o despacho térmico por modalidade, para a próxima semana operativa.

Figura 9 – Geração térmica para a próxima semana operativa

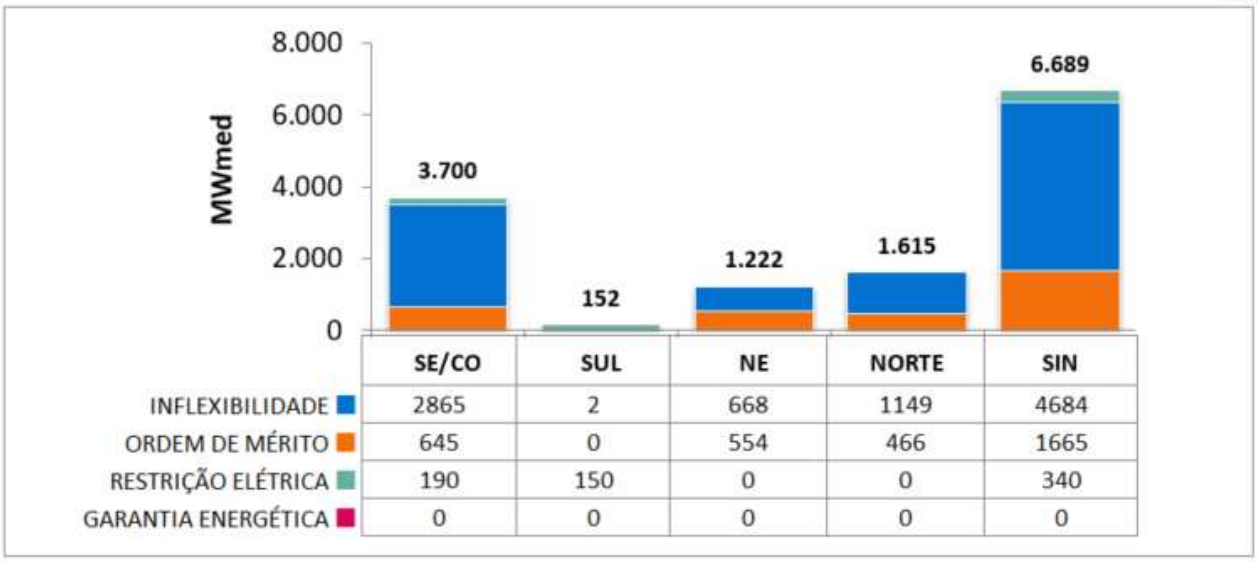

	SE/CO	SUL	NE	NORTE	SIN
INFLEXIBILIDADE	2865	2	668	1149	4684
ORDEM DE MÉRITO	645	0	554	466	1665
RESTRIÇÃO ELÉTRICA	190	150	0	0	340
GARANTIA ENERGÉTICA	0	0	0	0	0

Na tabela a seguir segue a Indicação de despacho antecipado por ordem de mérito de custo para a semana de 28/11 a 04/12/2020.

O conteúdo desta publicação foi produzido pelo ONS com base em dados e informações de conhecimento público. É de responsabilidade exclusiva dos agentes e demais interessados a obtenção de outros dados e informações, a realização de análises, estudos e avaliações para fins de tomada de decisões, definição de estratégias de atuação, assunção de compromissos e obrigações e quaisquer outras finalidades, em qualquer tempo e sob qualquer condição. É proibida a reprodução ou utilização total ou parcial do presente sem a identificação da fonte.

Tabela 5 – UTEs com contrato de combustível GNL

UTE			Benefício (R$/MWh)		
Nome	Cod	CVU (R$/MWh)	Carga Pesada	Carga Média	Carga Leve
SANTA CRUZ	86	178,56	107,14 (2)	107,14 (2)	107,14 (2)
LUIZORMELO	15	270,71	107,14 (2)	107,14 (2)	107,14 (2)
PSERGIPE I	224	214,84	98,95 (2)	98,54 (2)	95,96 (2)

(1) Comandado o despacho antecipado por ordem de mérito de custo nesse patamar

(2) NÃO foi comandado o despacho antecipado por ordem de mérito de custo nesse patamar

Apesar da UTE Luiz O. R. Melo não estar despachada por ordem de mérito, há necessidade do despacho de, pelo menos, 204 MW dessa usina para reduzir o risco de corte de carga na região de Governador Valadares e na região Norte do Espírito Santo. Desta forma, a UTE Luiz O. R. Melo deverá ser despachada por razão elétrica, na referida semana, em 204 MW.

9. IMPORTAÇÃO DE ENERGIA DA REPÚBLICA ORIENTAL DO URUGUAI

9.1. República Oriental do Uruguai

Para a próxima semana operativa, foram declaradas as seguintes ofertas de importação de energia da República Oriental do Uruguai para o Sistema Interligado Nacional - SIN através das conversoras de Rivera (70 MW) e Melo (500 MW).

- **Eletrobras**

Tabela 6 – Energia Ofertada para Importação

	Oferta de Energia para a Semana de 26/9 a 2/10 (MWmed)			
	Bloco 1	Bloco 2	Bloco 3	Total
Carga Pesada	120,0	40,0	185,0	345,0
Carga Média	120,0	40,0	185,0	345,0
Carga Leve	120,0	40,0	185,0	345,0
CVU (R$/MWh)	157,94	185,20	394,88	

- **Enel**

Conforme declaração do agente, esta importação poderá ser realizada exclusivamente pela conversora Melo.

Tabela 7 – Energia Ofertada para Importação

	Oferta de Energia para a Semana de 26/9 a 2/10 (MWmed)		
	Bloco 1	Bloco 2	Total
Carga Pesada	40,0	185,0	225,0
Carga Média	40,0	185,0	225,0
Carga Leve	40,0	185,0	225,0
CVU (R$/MWh)	185,51	395,39	

O conteúdo desta publicação foi produzido pelo ONS com base em dados e informações de conhecimento público. É de responsabilidade exclusiva dos agentes e demais interessados a obtenção de outros dados e informações, a realização de análises, estudos e avaliações para fins de tomada de decisões, definição de estratégias de atuação, assunção de compromissos e obrigações e quaisquer outras finalidades, em qualquer tempo e sob qualquer condição. É proibida a reprodução ou utilização total ou parcial do presente sem a identificação da fonte.

9.2. República da Argentina

- **Enel**

Para a próxima semana operativa, foi declarada a seguinte oferta de importação de energia da República da Argentina para o SIN através das conversoras de Garabi 1 (1.100 MW) e Garabi 2 (1.100 MW).

Tabela 8 – Energia Ofertada para Importação

	Oferta de Energia para a Semana de 26/9 a 2/10 (MWmed)			
	Bloco 1	Bloco 2	Bloco 3	Total
Carga Pesada	250,0	400,0	300,0	950,0
Carga Média	250,0	400,0	300,0	950,0
Carga Leve	250,0	400,0	300,0	950,0
CVU (R$/MWh)	239,59	380,09	616,57	

Nota: Detalhes sobre a importação de energia vide Portaria Nº 339, de 15 de Agosto de 2018 disponível em: http://pesquisa.in.gov.br/imprensa/jsp/visualiza/index.jsp?data=17/08/2018&jornal=515&pagina=60&totalArquivos=136

10. ESTIMATIVA DE ENCARGOS OPERATIVOS

A tabela a seguir apresenta a expectativa do custo de despacho térmico por restrição elétrica para esta semana operativa.

Tabela 9 – Expectativa de custo de despacho térmico por Restrição Elétrica

UTE Potência Instalada (MW)	CVU (R$/MWh)	Geração (MWmed)			ESS ELÉTRICO
		Carga Pesada	Carga Média	Carga Leve	
LUIZORMELO (204)	R$ 270,71	190,0	190,0	190,0	**R$ 3.254.776,00**
TOTAL SE/CO					R$ 3.254.776,00

O conteúdo desta publicação foi produzido pelo ONS com base em dados e informações de conhecimento público. É de responsabilidade exclusiva dos agentes e demais interessados a obtenção de outros dados e informações, a realização de análises, estudos e avaliações para fins de tomada de decisões, definição de estratégias de atuação, assunção de compromissos e obrigações e quaisquer outras finalidades, em qualquer tempo e sob qualquer condição. É proibida a reprodução ou utilização total ou parcial do presente sem a identificação da fonte.

11. ARMAZENAMENTOS OPERATIVOS

Para uma melhor avaliação de diversos cenários hidrometeorológicos, notadamente, aqueles de curto prazo e suas influências nas previsões de vazões nos subsistemas, os resultados deste PMO contemplam cenários de afluências visando melhor representar a ocorrência de precipitação e, consequentemente, seus efeitos sobre as afluências e armazenamentos.

Além dos resultados associados ao valor esperado das previsões de afluências, as simulações operativas também foram realizadas com os limites superior e inferior das previsões de afluências. Apresentamos a seguir os resultados obtidos com a aplicação dos diferentes cenários de afluência.

Tabela 10 – Previsão de ENA dos cenários de sensibilidade

Subsistema	ENERGIAS NATURAIS AFLUENTES					
	Previsão Mensal					
	LI		VE		LS	
	(MWmed)	%MLT	(MWmed)	%MLT	(MWmed)	%MLT
Sudeste	11.754	**49**	16.111	**68**	20.475	**86**
Sul	3.595	**27**	8.148	**61**	12.733	**95**
Nordeste	1.347	**41**	1.877	**58**	2.445	**75**
Norte	1.172	**49**	1.484	**62**	1.814	**75**

Tabela 11 – Previsão de %EARmáx para o final do mês

Subsistema	% EARmáx 25/9	% EARmáx - 31/10		
	NÍVEL INICIAL	NÍVEL PMO		
	VE	LI	VE	LS
Sudeste	34,7	25,3	28,0	30,4
Sul	45,9	21,4	29,6	46,2
Nordeste	67,8	49,4	49,8	50,9
Norte	53,2	33,3	32,7	33,5

O conteúdo desta publicação foi produzido pelo ONS com base em dados e informações de conhecimento público. É de responsabilidade exclusiva dos agentes e demais interessados a obtenção de outros dados e informações, a realização de análises, estudos e avaliações para fins de tomada de decisões, definição de estratégias de atuação, assunção de compromissos e obrigações e quaisquer outras finalidades, em qualquer tempo e sob qualquer condição. É proibida a reprodução ou utilização total ou parcial do presente sem a identificação da fonte.

12. RESERVATÓRIOS EQUIVALENTES DE ENERGIA

A seguir são apresentadas as previsões de Energia Natural Afluente para a próxima semana operativa e para o mês de outubro, bem como as previsões de Energia Armazenada nos Reservatórios Equivalentes de Energia – REE, deste PMO.

Tabela 12 – Previsão de ENA por REE

Valor Esperado das Energias Naturais Afluentes				
REE	Previsão Semanal		Previsão Mensal	
	26/09/2020 a 02/10/2020		out/20	
	(MWmed)	%MLT	(MWmed)	%MLT
Sudeste	1.735	66	2.206	71
Madeira	1.388	73	1.782	83
Teles Pires	505	69	623	74
Itaipu	2.216	78	2.847	86
Paraná	5.581	53	7.628	65
Paranapanema	751	34	1.014	40
Sul	3.924	56	5.433	77
Iguaçu	1.246	24	2.716	43
Nordeste	1.847	60	1.877	58
Norte	781	50	1.059	62
Belo Monte	109	28	158	37
Manaus	334	87	290	107

Tabela 13 – Previsão de %EARmáx por REE

% Energia Armazenável Máxima		
REE	Previsão Semanal	Previsão Mensal
	2-out	31-out
	(%EARmáx)	(%EARmáx)
Sudeste	34,2	28,9
Madeira	25,5	12,3
Teles Pires	11,1	19,2
Itaipu	53,7	99,4
Paraná	31,6	26,0
Paranapanema	42,7	44,9
Sul	55,3	48,6
Iguaçu	28,4	12,4
Nordeste	64,5	49,8
Norte	49,7	33,5
Belo Monte	86,3	87,0
Manaus	30,1	16,6

O conteúdo desta publicação foi produzido pelo ONS com base em dados e informações de conhecimento público. É de responsabilidade exclusiva dos agentes e demais interessados a obtenção de outros dados e informações, a realização de análises, estudos e avaliações para fins de tomada de decisões, definição de estratégias de atuação, assunção de compromissos e obrigações e quaisquer outras finalidades, em qualquer tempo e sob qualquer condição. É proibida a reprodução ou utilização total ou parcial do presente sem a identificação da fonte.

13. DESPACHO TÉRMICO POR MODALIDADE, PATAMAR DE CARGA E USINA

Nas tabelas abaixo, a diferenciação entre geração por inflexibilidade e por ordem de mérito tem caráter informativo, com o objetivo de detalhar a informação de inflexibilidade enviada pelos respectivos agentes para o PMO. Ressalta-se que nas etapas de Programação Diária e Tempo Real, o montante despachado nas usinas termelétricas indicadas por ordem de mérito é plenamente intitulado como ordem de mérito.

REGIÃO SUDESTE/CENTRO-OESTE																	
Combustível	Combustível	CVU (R$/MWh)	Inflexibilidade			Ordem de Mérito			Total Mérito e INFL.			Razão Elétrica			Total UTE		
			P	M	L	P	M	L	P	M	L	P	M	L	P	M	L
ATLAN_CSA (255)	Resíduos	0,00	176,9	176,9	176,9				176,9	176,9	176,9				176,9	176,9	176,9
ANGRA 2 (1350)	Nuclear	20,12	1220,0	1220,0	1220,0	0,0	0,0	0,0	1220,0	1220,0	1220,0				1220,0	1220,0	1220,0
ANGRA 1 (640)	Nuclear	31,17	640,0	640,0	640,0	0,0	0,0	0,0	640,0	640,0	640,0				640,0	640,0	640,0
NORTEFLU 1 (400)	Gás	82,25	400,0	400,0	400,0	0,0	0,0	0,0	400,0	400,0	400,0				400,0	400,0	400,0
NORTEFLU 2 (100)	Gás	93,32				100,0	100,0	100,0	100,0	100,0	100,0				100,0	100,0	100,0
UTE STA VI (41)	Biomassa	116,91	14,0	14,0	14,0	24,5	24,5	24,5	38,5	38,5	38,5				38,5	38,5	38,5
BAIXADA FL (530)	Gás	158,04				520,0	520,0	520,0	520,0	520,0	520,0				520,0	520,0	520,0
SANTA CRUZ (500)	GNL	178,56															
NORTEFLU 3 (200)	Gás	179,16															
ATLANTICO (235)	Resíduos	192,78	218,7	218,7	218,7				218,7	218,7	218,7				218,7	218,7	218,7
T.LAGOAS (350)	Gás	224,42															
TERMORIO (1036)	Gás	267,70	150,0	150,0	150,0				150,0	150,0	150,0				150,0	150,0	150,0
LUIZORMELO (204)	GNL	270,71										190,0	190,0	190,0	190,0	190,0	190,0
JUIZ DE FO (87)	Gás	283,74															
CUIABA CC (529)	Gás	309,71															
ST.CRUZ 34 (436)	Óleo	310,41															
CUBATAO (216)	Gás	334,58	45,0	45,0	45,0				45,0	45,0	45,0				45,0	45,0	45,0
SEROPEDICA (386)	Gás	343,57															
IBIRITE (226)	Gás	346,37															
NORTEFLU 4 (127)	Gás	419,87															
PIRAT.12 O (200)	Gás	470,34															
NPIRATINGA (572)	Gás	548,04															
T.MACAE (929)	Gás	612,01															
VIANA (175)	Óleo	672,98															
TNORTE 2 (340)	Óleo	910,86															
PALMEIR_GO (176)	Diesel	924,84															
IGARAPE (131)	Óleo	939,55															
CAMPOS (25)	Gás	978,10															
DAIA (44)	Diesel	1178,66															
GOIANIA 2 (140)	Diesel	1235,79															
XAVANTES (54)	Diesel	1695,17															
TOTAL SE/CO (10634)			2864,60	2864,60	2864,60	644,5	644,5	644,5	3509,1	3509,1	3509,1	190,0	190,0	190,0	3699,1	3699,1	3699,1

REGIÃO SUL																	
Combustível	Combustível	CVU (R$/MWh)	Inflexibilidade			Ordem de Mérito			Total Mérito e INFL.			Razão Elétrica			Total UTE		
			P	M	L	P	M	L	P	M	L	P	M	L	P	M	L
PAMPA SUL (345)	Carvão	67,12				0,0	0,0	0,0	0,0	0,0	0,0				0,0	0,0	0,0
SAO SEPE (8)	Biomassa	84,44				0,0	0,0	0,0	0,0	0,0	0,0				0,0	0,0	0,0
CANDIOTA_3 (350)	Carvão	86,65				0,0	0,0	0,0	0,0	0,0	0,0				0,0	0,0	0,0
J.LACER. C (363)	Carvão	206,84															
J.LACER. B (262)	Carvão	244,14										80,0	80,0	80,0	80,0	80,0	80,0
J.LAC. A2 (132)	Carvão	245,21										35,0	35,0	35,0	35,0	35,0	35,0
J.LAC. A1 (100)	Carvão	270,48										35,0	35,0	35,0	35,0	35,0	35,0
URUGUAIANA (640)	Gás	278,48															
MADEIRA (4)	Biomassa	310,67	2,0	2,0	2,0				2,0	2,0	2,0				2,0	2,0	2,0
FIGUEIRA (20)	Carvão	475,68															
ARAUCARIA (484)	Gás	641,69															
CANOAS (249)	Diesel	698,14															
TOTAL SUL (2957)			2,00	2,00	2,00	0,0	0,0	0,0	2,0	2,0	2,0	150,0	150,0	150,0	152,0	152,0	152,0

O conteúdo desta publicação foi produzido pelo ONS com base em dados e informações de conhecimento público. É de responsabilidade exclusiva dos agentes e demais interessados a obtenção de outros dados e informações, a realização de análises, estudos e avaliações para fins de tomada de decisões, definição de estratégias de atuação, assunção de compromissos e obrigações e quaisquer outras finalidades, em qualquer tempo e sob qualquer condição. É proibida a reprodução ou utilização total ou parcial do presente sem a identificação da fonte.

REGIÃO NORDESTE

Combustível	Combustível	CVU (R$/MWh)	Inflexibilidade			Ordem de Mérito			Total Mérito e INFL.			Razão Elétrica			Total UTE		
			P	M	L	P	M	L	P	M	L	P	M	L	P	M	L
P.PECEM1 (720)	Carvão	158,02				720,0	720,0	248,9	720,0	720,0	248,9				720,0	720,0	248,9
PROSPERIDA (28)	Gás	159,37				28,0	28,0		28,0	28,0					28,0	28,0	0,0
TERMOPE (533)	Gás	160,86	372,0	372,0	372,0	147,9			519,9	372,0	372,0				519,9	372,0	372,0
P.PECEM2 (365)	Carvão	168,90															
PSERGIPE I (1516)	GNL	214,84															
FORTALEZA (327)	Gás	223,72															
T.BAHIA (186)	Gás	265,09	150,0	150,0	150,0				150,0	150,0	150,0				150,0	150,0	150,0
VALE ACU (368)	Gás	266,23	120,0	120,0	120,0				120,0	120,0	120,0				120,0	120,0	120,0
T.CAMACARI (120)	Gás	345,02															
TERMOCEARA (223)	Gás	371,12															
SYKUE I (30)	Biomassa	510,12	26,0	26,0	26,0				26,0	26,0	26,0				26,0	26,0	26,0
PERNAMBU_3 (201)	Óleo	574,39															
MARACANAU (168)	Óleo	651,00															
TERMOCABO (50)	Óleo	664,88															
TERMONE (171)	Óleo	669,82															
TERMOPB (171)	Óleo	669,82															
CAMPINA_GR (169)	Óleo	672,99															
SUAPE II (381)	Óleo	679,41															
BAHIA_1 (31)	Óleo	731,06															
GLOBAL I (149)	Óleo	763,42															
GLOBAL II (149)	Óleo	763,42															
ALTOS (13)	Diesel	1024,21															
ARACATI (11)	Diesel	1024,21															
BATURITE (11)	Diesel	1024,21															
C.MAIOR (13)	Diesel	1024,21															
CAUCAIA (15)	Diesel	1024,21															
CRATO (13)	Diesel	1024,21															
IGUATU (15)	Diesel	1024,21															
JUAZEIRO N (15)	Diesel	1024,21															
MARAMBAIA (13)	Diesel	1024,21															
NAZARIA (13)	Diesel	1024,21															
PECEM (15)	Diesel	1024,21															
AREMBEPE (150)	Óleo	1167,53															
MURICY (147)	Óleo	1167,53															
POTIGUAR_3 (66)	Diesel	1223,15															
POTIGUAR (53)	Diesel	1223,16															
PETROLINA (136)	Óleo	1280,95															
PAU FERRO (94)	Diesel	1379,56															
TERMOMANAU (143)	Diesel	1379,56															
TOTAL NE (6992)			668,00	668,00	668,00	895,9	748,0	248,9	1563,9	1416,0	916,9	0,0	0,0	0,0	1563,9	1416,0	916,9

REGIÃO NORTE

Combustível	Combustível	CVU (R$/MWh)	Inflexibilidade			Ordem de Mérito			Total Mérito e INFL.			Razão Elétrica			Total UTE		
			P	M	L	P	M	L	P	M	L	P	M	L	P	M	L
C. ROCHA (85)	Gás	0,00	65,0	65,0	65,0				65,0	65,0	65,0				65,0	65,0	65,0
JARAQUI (75)	Gás	0,00	63,0	63,0	63,0				63,0	63,0	63,0				63,0	63,0	63,0
MANAUARA (67)	Gás	0,00	64,5	64,5	64,5				64,5	64,5	64,5				64,5	64,5	64,5
PONTA NEGR (66)	Gás	0,00	64,0	64,0	64,0				64,0	64,0	64,0				64,0	64,0	64,0
TAMBAQUI (93)	Gás	0,00	63,0	63,0	63,0				63,0	63,0	63,0				63,0	63,0	63,0
APARECIDA (166)	Gás	68,11	75,0	75,0	75,0	48,0	41,7	35,8	123,0	116,7	110,8				123,0	116,7	110,8
UTE MAUA 3 (591)	Gás	68,11	264,0	264,0	264,0	326,8	326,8	326,8	590,8	590,8	590,8				590,8	590,8	590,8
MARANHAO3 (519)	Gás	82,48	490,0	490,0	490,0	0,0	25,8	23,0	490,0	515,8	513,0				490,0	515,8	513,0
PARNAIB_IV (56)	Gás	151,69				56,3	56,3	56,3	56,3	56,3	56,3				56,3	56,3	56,3
P. ITAQUI (360)	Carvão	163,42				84,0			84,0						84,0	0,0	0,0
MARANHAO V (338)	Gás	165,14															
MARANHAOIV (338)	Gás	165,14															
N.VENECIA2 (270)	Gás	223,51															
GERAMAR1 (166)	Óleo	672,97															
GERAMAR2 (166)	Óleo	672,97															
TOTAL NORTE (3356)			1148,50	1148,50	1148,50	515,1	450,6	441,9	1663,6	1599,1	1590,4	0,0	0,0	0,0	1663,6	1599,1	1590,4

O conteúdo desta publicação foi produzido pelo ONS com base em dados e informações de conhecimento público. É de responsabilidade exclusiva dos agentes e demais interessados a obtenção de outros dados e informações, a realização de análises, estudos e avaliações para fins de tomada de decisões, definição de estratégias de atuação, assunção de compromissos e obrigações e quaisquer outras finalidades, em qualquer tempo e sob qualquer condição. É proibida a reprodução ou utilização total ou parcial do presente sem a identificação da fonte.