1. APRESENTAÇÃO

Na semana de 17/10 a 23/10/2020 houve chuva fraca nas bacias dos rios Paranapanema, Tietê, Grande, Paranaíba e no alto São Francisco, Tocantins e na calha principal do Paraná.

Na semana de 24/10 a 30/10/2020 deve ocorrer precipitação nas bacias dos rios Tietê, Grande, Paranaíba, São Francisco e Tocantins. As bacias hidrográficas da região Sul apresentam chuva fraca no início da semana.

Para a semana operativa de 24/10 a 30/10/2020, houve oferta de energia da República Oriental do Uruguai e República da Argentina. De acordo com o Art. 2º da Portaria MME nº 339, de 15 de agosto de 2018, as ofertas para importação de energia não foram consideradas na elaboração do PMO.

Os valores médios semanais do Custo Marginal de Operação – CMO dos subsistemas do SIN sofreram as seguintes alterações em relação à semana anterior:

- SE/CO: de R$ 318,74/MWh para R$ 318,62/MWh
- Sul: de R$ 318,74/MWh para R$ 318,62/MWh
- Nordeste: de R$ 216,12/MWh para R$ 172,61/MWh
- Norte: de R$ 318,74/MWh para R$ 318,62/MWh

Desde o dia 01/01/2020, o despacho por ordem de mérito é indicado diariamente pelos resultados do modelo DESSEM. Assim, o despacho por ordem de mérito semanal, conforme publicado nesse documento, tem caráter apenas informativo.

2. NOTÍCIAS

Nos dias 29 e 30 de outubro será realizada a reunião de elaboração do PMO Novembro de 2020, com transmissão ao vivo através do site do ONS.

Como medida adicional de prevenção ao Coronavírus, o ONS informa que está suspensa, temporariamente, a participação presencial nas reuniões.

3. ANÁLISE DAS CONDIÇÕES HIDROMETEOROLÓGICAS

3.1. PREVISÃO PARA A PRÓXIMA SEMANA

Na próxima semana a atuação de um sistema de baixa pressão nas regiões Centro-Oeste, Norte e Sudeste ocasiona precipitação nas bacias dos rios Tietê, Grande, Paranaíba, São Francisco e Tocantins. As bacias hidrográficas da região Sul apresentam chuva fraca no início da semana devido ao avanço de um sistema de baixa pressão **(Figura 1).**

O conteúdo desta publicação foi produzido pelo ONS com base em dados e informações de conhecimento público. É de responsabilidade exclusiva dos agentes e demais interessados a obtenção de outros dados e informações, a realização de análises, estudos e avaliações para fins de tomada de decisões, definição de estratégias de atuação, assunção de compromissos e obrigações e quaisquer outras finalidades, em qualquer tempo e sob qualquer condição. É proibida a reprodução ou utilização total ou parcial do presente sem a identificação da fonte.

Figura 1 - Precipitação acumulada prevista pelo modelo ECMWF (ECMWF) para o período de 24 a 30/10/2020

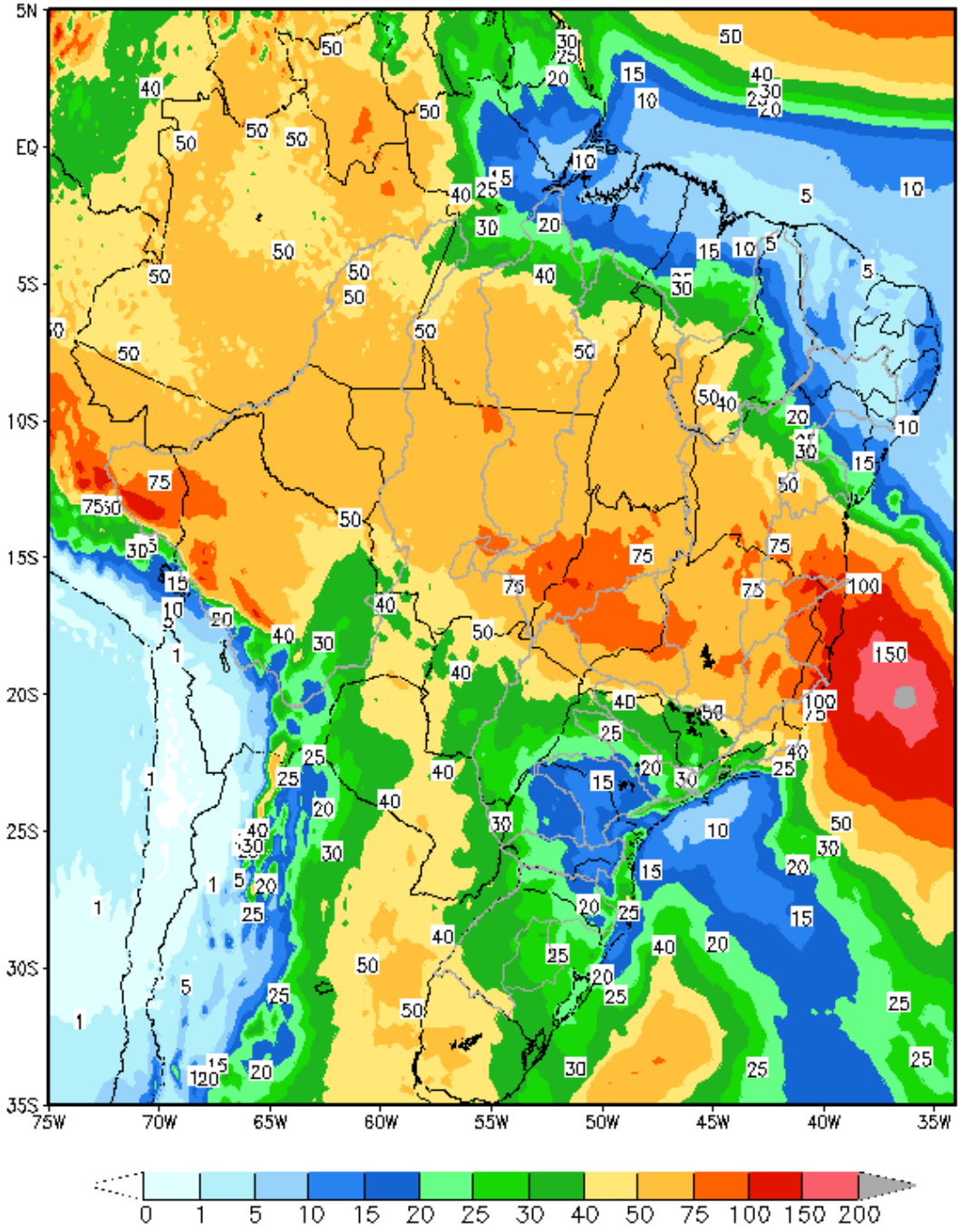

Em comparação com os valores estimados para a semana em curso, prevê-se para a próxima semana operativa ascensão nas afluências dos subsistemas Sudeste e Norte, leve recessão para o subsistema Sul e estabilidade nas afluências do subsistema Nordeste. A previsão mensal para outubro indica a ocorrência de afluências abaixo da média histórica para todos os subsistemas.

O conteúdo desta publicação foi produzido pelo ONS com base em dados e informações de conhecimento público. É de responsabilidade exclusiva dos agentes e demais interessados a obtenção de outros dados e informações, a realização de análises, estudos e avaliações para fins de tomada de decisões, definição de estratégias de atuação, assunção de compromissos e obrigações e quaisquer outras finalidades, em qualquer tempo e sob qualquer condição. É proibida a reprodução ou utilização total ou parcial do presente sem a identificação da fonte.

Tabela 1 – Previsão de ENAs da revisão 4 de outubro/2020

Revisão 4 do PMO de Outubro/2020 - ENAs previstas				
Subsistema	24/10 a 30/10/2020		Mês de Outubro	
	MWmed	%MLT	MWmed	%MLT
SE/CO	14.630	62	12.055	51
S	2.247	17	2.922	22
NE	1.442	44	1.529	47
N	1.573	65	1.388	58

4. PREVISÃO DE CARGA

As atividades econômicas continuam em recuperação (produção industrial, comércio, serviços, etc), pós efeito do isolamento social em função da pandemia, o que tem se refletido positivamente no comportamento da carga.

As previsões meteorológicas para a próxima semana indicam para as capitais do subsistema Sudeste/Centro-Oeste, temperaturas em média, semelhantes às observadas na semana atual, que apresentou temperaturas mais amenas que as duas primeiras semanas operativas do mês em análise. Ressalta-se que durante a próxima semana há expectativa de chuva fraca, principalmente no Rio de janeiro, mas com sensação de abafamento após sua passagem.

No subsistema Sul há expectativa de ocorrência de temperaturas mais elevadas nos primeiros dias da semana operativa, mas em seguida as temperaturas entram em declínio associada a entrada de massas de ar frio em função da passagem de duas frentes frias.

As capitais das regiões Nordeste e Norte seguem com temperaturas típicas para essa época do ano e semelhantes ao comportamento observado ao longo das últimas semanas. Destaque-se nesse período, ocorrência de precipitação no Sul da Bahia.

As taxas de crescimento previstas para o mês de outubro em relação ao mesmo mês de 2019, são de 1,7% no subsistema Sudeste/Centro-Oeste, 6,7% para o subsistema Sul, 4,3% no Nordeste e 5,9% no subsistema do Norte.

No subsistema Norte o retorno da carga de um consumidor livre da rede básica justifica em parte, a taxa de crescimento observada nesse subsistema.

Tabela 2 – Evolução da carga do PMO de outubro/2020

Subsistema	CARGA SEMANAL (MWmed)						CARGA MENSAL (MWmed)	
	1ª Sem	2ª Sem	3ª Sem	4ª Sem	5ª Sem	6ª Sem	out/20	Var. (%) out/20 -> out/19
Sudeste	43.496	44.374	40.081	40.044	40.794	40.182	41.427	1,7%
Sul	12.596	12.571	11.737	12.882	12.748	12.331	12.487	6,7%
Nordeste	11.499	11.938	11.870	11.993	11.973	11.565	11.903	4,3%
Norte	5.871	5.972	5.856	6.075	6.095	5.963	5.990	5,9%
SIN	73.462	74.855	69.544	70.994	71.610	70.041	71.807	3,3%

O conteúdo desta publicação foi produzido pelo ONS com base em dados e informações de conhecimento público. É de responsabilidade exclusiva dos agentes e demais interessados a obtenção de outros dados e informações, a realização de análises, estudos e avaliações para fins de tomada de decisões, definição de estratégias de atuação, assunção de compromissos e obrigações e quaisquer outras finalidades, em qualquer tempo e sob qualquer condição. É proibida a reprodução ou utilização total ou parcial do presente sem a identificação da fonte.

5. PRINCIPAIS RESULTADOS

5.1. CUSTO MARGINAL DE OPERAÇÃO (CMO)

A tabela a seguir apresenta o CMO, por subsistema e patamar de carga para próxima semana operativa.

Tabela 3 – CMO por patamar de carga

Patamares de Carga	CMO (R$/MWh)			
	SE/CO	S	NE	N
Pesada	327,15	327,15	185,27	327,15
Média	326,83	326,83	168,26	326,83
Leve	309,38	309,38	166,77	309,38
Média Semanal	318,62	318,62	172,61	318,62

Na figura a seguir é apresentada a evolução do CMO médio semanal ao longo deste PMO.

Figura 2 – Evolução semanal do CMO

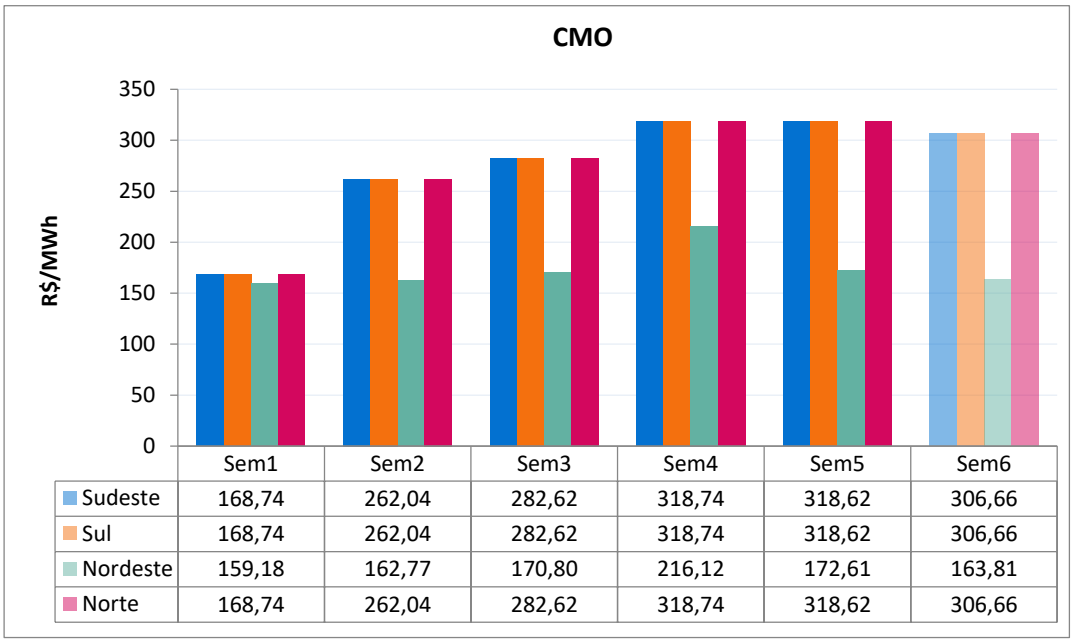

	Sem1	Sem2	Sem3	Sem4	Sem5	Sem6
Sudeste	168,74	262,04	282,62	318,74	318,62	306,66
Sul	168,74	262,04	282,62	318,74	318,62	306,66
Nordeste	159,18	162,77	170,80	216,12	172,61	163,81
Norte	168,74	262,04	282,62	318,74	318,62	306,66

5.2. POLÍTICA DE OPERAÇÃO ENERGÉTICA

Para esta semana operativa, está prevista a seguinte política de intercâmbio de energia entre regiões:

Região SE/CO → Geração dimensionada para fechamento do balanço energético do SIN.

Região Sul → Geração dimensionada de forma a otimizar os recursos desta região.

Região NE → Intercâmbio de energia definido em função dos recursos energéticos da região, buscando-se a máxima exploração, respeitando-se os limites elétricos vigentes para o subsistema.

Região Norte → Geração dimensionada de forma a otimizar os recursos desta região e buscando-se a aderência a curva guia para o armazenamento da UHE Tucuruí.

O conteúdo desta publicação foi produzido pelo ONS com base em dados e informações de conhecimento público. É de responsabilidade exclusiva dos agentes e demais interessados a obtenção de outros dados e informações, a realização de análises, estudos e avaliações para fins de tomada de decisões, definição de estratégias de atuação, assunção de compromissos e obrigações e quaisquer outras finalidades, em qualquer tempo e sob qualquer condição. É proibida a reprodução ou utilização total ou parcial do presente sem a identificação da fonte.

6. ANÁLISE DA VARIAÇÃO SEMANAL DO CMO

Esta análise visa identificar os principais parâmetros cujas atualizações impactaram os CMO desta revisão do PMO, em comparação com os valores obtidos na revisão anterior.

Foram realizados 8 estudos, onde caso inicial foi construído com base nos dados oficiais da última revisão deste PMO. Neste primeiro estudo a partida dos reservatórios foi estimada conforme indicado para esta semana na última revisão.

O segundo estudo foi realizado com os dados do caso inicial sendo substituída previsão de vazões para esta revisão.

A partir do conjunto de dados do segundo estudo foram elaborados os demais casos onde foram atualizados, sequencialmente, as seguintes informações: previsão de vazão, níveis de partida dos reservatórios, previsão de carga, disponibilidade das usinas, limites elétricos, restrições hidráulicas e por fim os demais dados que compõe toda a informação referente a atual revisão.

As atualizações da previsão de vazões e os níveis de partida declarados pelos agentes apontaram para uma elevação do CMO dos subsistemas Sudeste/Centro-Oeste, Sul e Norte. Entretanto, a carga prevista para a próxima semana do SIN deve ficar em torno de 3,0 GWmed mais baixa em relação à previsão anterior, indicando a redução do CMO. Dessa maneira, o CMO para esses subsistemas não sofreu alteração significativa em relação à semana anterior.

Figura 3 – Análise da variação do CMO nos subsistemas SE/CO, Sul e Norte

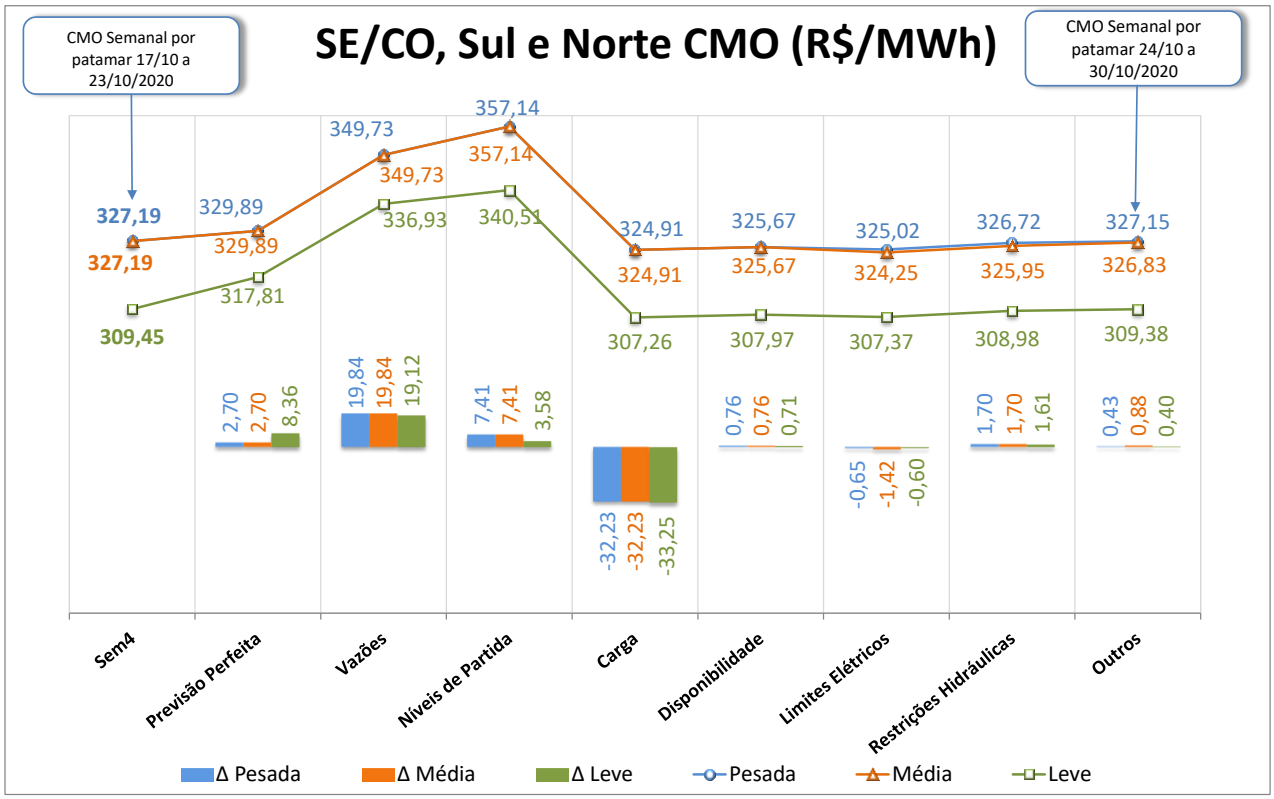

O conteúdo desta publicação foi produzido pelo ONS com base em dados e informações de conhecimento público. É de responsabilidade exclusiva dos agentes e demais interessados a obtenção de outros dados e informações, a realização de análises, estudos e avaliações para fins de tomada de decisões, definição de estratégias de atuação, assunção de compromissos e obrigações e quaisquer outras finalidades, em qualquer tempo e sob qualquer condição. É proibida a reprodução ou utilização total ou parcial do presente sem a identificação da fonte.

O principal fator que influenciou na redução do CMO do subsistema Nordeste foi a atualização das disponibilidades das usinas, conforme informações enviadas pelo agentes.

Figura 4 – Análise da variação do CMO no subsistema Nordeste

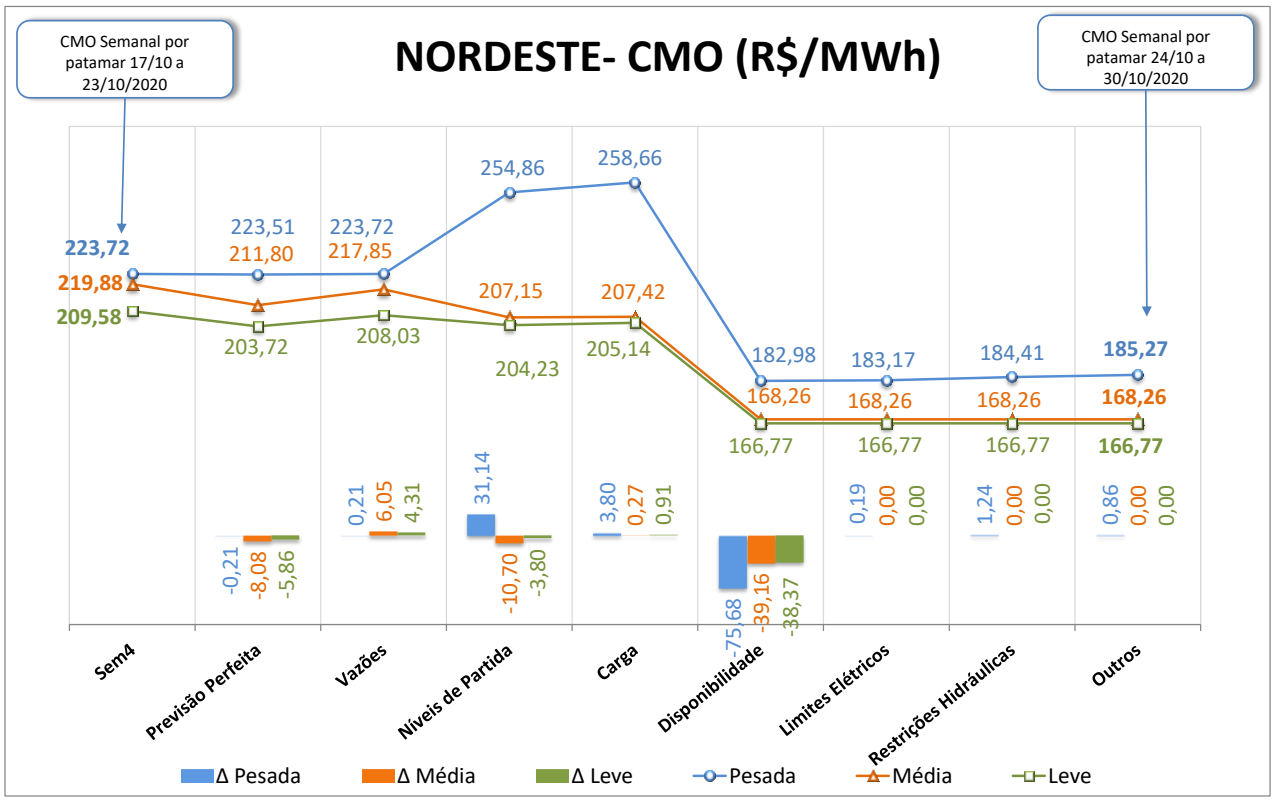

O conteúdo desta publicação foi produzido pelo ONS com base em dados e informações de conhecimento público. É de responsabilidade exclusiva dos agentes e demais interessados a obtenção de outros dados e informações, a realização de análises, estudos e avaliações para fins de tomada de decisões, definição de estratégias de atuação, assunção de compromissos e obrigações e quaisquer outras finalidades, em qualquer tempo e sob qualquer condição. É proibida a reprodução ou utilização total ou parcial do presente sem a identificação da fonte.

7. GERAÇÃO TÉRMICA

A Figura 5 apresenta, para cada subsistema, o despacho térmico por modalidade, para a próxima semana operativa.

Figura 5 – Geração térmica para a próxima semana operativa

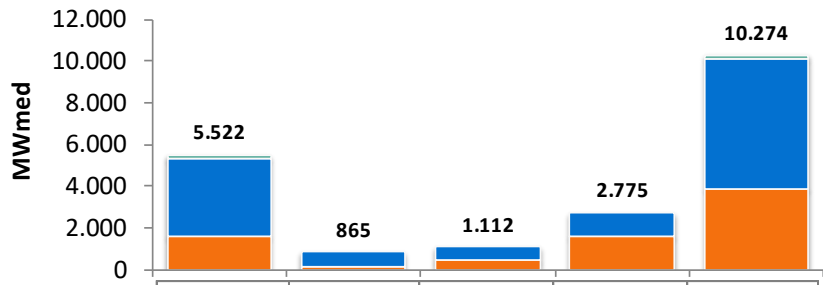

	SE/CO	SUL	NE	NORTE	SIN
INFLEXIBILIDADE	3692	731	656	1149	6228
ORDEM DE MÉRITO	1643	134	456	1626	3859
RESTRIÇÃO ELÉTRICA	187	0	0	0	187
GARANTIA ENERGÉTICA	0	0	0	0	0

Na tabela abaixo segue a Indicação de despacho antecipado por ordem de mérito de custo para a semana de 26/12/2020 a 01/01/2021.

Tabela 4 – UTEs com contrato de combustível GNL

UTE			Benefício (R$/MWh)		
Nome	Cod	CVU (R$/MWh)	Carga Pesada	Carga Média	Carga Leve
SANTA CRUZ	86	145,99	139,73 (2)	139,73 (2)	139,73 (2)
LUIZORMELO	15	218,79	139,73 (2)	139,73 (2)	139,73 (2)
PSERGIPE I	224	196,76	131,89 (2)	129,72 (2)	122,93 (2)

(1) Comandado o despacho antecipado por ordem de mérito de custo nesse patamar

(2) NÃO foi comandado o despacho antecipado por ordem de mérito de custo nesse patamar

Apesar da UTE Luiz O. R. Melo não estar despachada por ordem de mérito, há necessidade do despacho de, pelo menos, 204 MW dessa usina para reduzir o risco de corte de carga na região de Governador Valadares e na região Norte do Espírito Santo. Desta forma, a UTE Luiz O. R. Melo deverá ser despachada por razão elétrica, na referida semana, em 204 MW.

Adicionalmente, para atender os critérios de segurança, durante as Festas de Fim de Ano, recomenda-se o despacho da UTE Santa Cruz em 150MW, nos períodos de 18h00 do dia 31/12 até 06h00 do dia 01/01/2021.

O conteúdo desta publicação foi produzido pelo ONS com base em dados e informações de conhecimento público. É de responsabilidade exclusiva dos agentes e demais interessados a obtenção de outros dados e informações, a realização de análises, estudos e avaliações para fins de tomada de decisões, definição de estratégias de atuação, assunção de compromissos e obrigações e quaisquer outras finalidades, em qualquer tempo e sob qualquer condição. É proibida a reprodução ou utilização total ou parcial do presente sem a identificação da fonte.

8. IMPORTAÇÃO DE ENERGIA DA REPÚBLICA ORIENTAL DO URUGUAI

8.1. República Oriental do Uruguai

Para a próxima semana operativa, foram declaradas as seguintes ofertas de importação de energia da República Oriental do Uruguai para o Sistema Interligado Nacional - SIN através das conversoras de Rivera (70 MW) e Melo (500 MW).

- **Eletrobras**

Tabela 5 – Energia Ofertada para Importação

	Oferta de Energia para a Semana de 24/10 a 30/10 (MWmed)		
	Bloco 1	Bloco 2	Total
Carga Pesada	0,0	285,0	285,0
Carga Média	0,0	285,0	285,0
Carga Leve	100,0	185,0	285,0
CVU (R$/MWh)	753,32	1035,48	

- **Enel**

Conforme declaração do agente, esta importação poderá ser realizada exclusivamente pela conversora Melo.

Tabela 6 – Energia Ofertada para Importação

	Oferta de Energia para a Semana de 24/10 a 30/10 (MWmed)		
	Bloco 1	Bloco 2	Total
Carga Pesada	0,0	285,0	285,0
Carga Média	0,0	285,0	285,0
Carga Leve	100,0	185,0	285,0
CVU (R$/MWh)	761,51	1049,15	

8.2. República da Argentina

- **Enel**

Para a próxima semana operativa, foi declarada a seguinte oferta de importação de energia da República da Argentina para o SIN através das conversoras de Garabi 1 (1.100 MW) e Garabi 2 (1.100 MW).

Tabela 7 – Energia Ofertada para Importação

	Oferta de Energia para a Semana de 24/10 a 30/10 (MWmed)				
	Bloco 1	Bloco 2	Bloco 3	Bloco 4	Total
Carga Pesada	200,0	300,0	400,0	400,0	1300,0
Carga Média	200,0	300,0	400,0	400,0	1300,0
Carga Leve	200,0	300,0	400,0	400,0	1300,0
CVU (R$/MWh)	351,96	419,06	623,24	725,62	

Nota: Detalhes sobre a importação de energia vide Portaria Nº 339, de 15 de Agosto de 2018 disponível em: http://pesquisa.in.gov.br/imprensa/jsp/visualiza/index.jsp?data=17/08/2018&jornal=515&pagina=60&totalArquivos=136

O conteúdo desta publicação foi produzido pelo ONS com base em dados e informações de conhecimento público. É de responsabilidade exclusiva dos agentes e demais interessados a obtenção de outros dados e informações, a realização de análises, estudos e avaliações para fins de tomada de decisões, definição de estratégias de atuação, assunção de compromissos e obrigações e quaisquer outras finalidades, em qualquer tempo e sob qualquer condição. É proibida a reprodução ou utilização total ou parcial do presente sem a identificação da fonte.

9. ESTIMATIVA DE ENCARGOS OPERATIVOS

Para esta semana operativa não há estimativa de encargos operativos.

10. ARMAZENAMENTOS OPERATIVOS

Para uma melhor avaliação de diversos cenários hidrometeorológicos, notadamente, aqueles de curto prazo e suas influências nas previsões de vazões nos subsistemas, os resultados desta revisão do PMO contemplam cenários de afluências visando melhor representar a ocorrência de precipitação e, consequentemente, seus efeitos sobre as afluências e armazenamentos.

Além dos resultados associados ao valor esperado das previsões de afluências, as simulações operativas também foram realizadas com os limites superior e inferior das previsões de afluências. Apresentamos a seguir os resultados obtidos com a aplicação dos diferentes cenários de afluência.

Tabela 8 – Previsão de ENA dos cenários de sensibilidade

Subsistema	ENERGIAS NATURAIS AFLUENTES					
	Previsão Mensal					
	LI		VE		LS	
	(MWmed)	%MLT	(MWmed)	%MLT	(MWmed)	%MLT
Sudeste	10.835	**46**	12.055	**51**	13.267	**56**
Sul	2.648	**20**	2.922	**22**	3.285	**24**
Nordeste	1.329	**41**	1.529	**47**	1.732	**53**
Norte	1.290	**54**	1.388	**58**	1.487	**62**

Tabela 9 – Previsão de %EARmáx para o final do mês

Subsistema	% EARmáx 23/10	% EARmáx - 31/10		
	NÍVEL INICIAL	NÍVEL PMO		
	VE	LI	VE	LS
Sudeste	25,2	22,7	23,3	24,0
Sul	27,1	20,0	20,3	21,2
Nordeste	58,5	53,7	54,1	54,6
Norte	33,4	31,5	32,3	32,4

O conteúdo desta publicação foi produzido pelo ONS com base em dados e informações de conhecimento público. É de responsabilidade exclusiva dos agentes e demais interessados a obtenção de outros dados e informações, a realização de análises, estudos e avaliações para fins de tomada de decisões, definição de estratégias de atuação, assunção de compromissos e obrigações e quaisquer outras finalidades, em qualquer tempo e sob qualquer condição. É proibida a reprodução ou utilização total ou parcial do presente sem a identificação da fonte.

11. RESERVATÓRIOS EQUIVALENTES DE ENERGIA

A seguir são apresentadas as previsões de Energia Natural Afluente para a próxima semana operativa e para o mês de outubro, bem como as previsões de Energia Armazenada nos Reservatórios Equivalentes de Energia – REE, desta revisão do PMO.

Tabela 10 – Previsão de ENA por REE

Valor Esperado das Energias Naturais Afluentes				
REE	Previsão Semanal		Previsão Mensal	
	24/10/2020 a 30/10/2020		out/20	
	(MWmed)	%MLT	(MWmed)	%MLT
Sudeste	2.516	80	1.896	61
Madeira	1.342	63	1.229	58
Teles Pires	502	59	481	57
Itaipu	2.220	67	1.946	59
Paraná	7.199	61	5.560	47
Paranapanema	843	33	937	37
Sul	1.296	18	1.650	23
Iguaçu	951	15	1.273	20
Nordeste	1.442	44	1.529	47
Norte	1.201	70	995	58
Belo Monte	185	43	129	30
Manaus	230	85	291	107

Tabela 11 – Previsão de %EARmáx por REE

% Energia Armazenável Máxima		
REE	Previsão Semanal	Previsão Mensal
	30-out	31-out
	(%EARmáx)	(%EARmáx)
Sudeste	29,0	28,9
Madeira	4,9	4,4
Teles Pires	13,6	12,6
Itaipu	6,8	5,8
Paraná	21,1	20,9
Paranapanema	31,2	31,2
Sul	32,2	31,9
Iguaçu	10,7	9,9
Nordeste	54,6	54,1
Norte	33,2	33,0
Belo Monte	84,7	85,0
Manaus	17,1	16,4

O conteúdo desta publicação foi produzido pelo ONS com base em dados e informações de conhecimento público. É de responsabilidade exclusiva dos agentes e demais interessados a obtenção de outros dados e informações, a realização de análises, estudos e avaliações para fins de tomada de decisões, definição de estratégias de atuação, assunção de compromissos e obrigações e quaisquer outras finalidades, em qualquer tempo e sob qualquer condição. É proibida a reprodução ou utilização total ou parcial do presente sem a identificação da fonte.

12. DESPACHO TÉRMICO POR MODALIDADE, PATAMAR DE CARGA E USINA

Nas tabelas abaixo, a diferenciação entre geração por inflexibilidade e por ordem de mérito tem caráter informativo, com o objetivo de detalhar a informação de inflexibilidade enviada pelos respectivos agentes para esta revisão do PMO. Ressalta-se que nas etapas de Programação Diária e Tempo Real, o montante despachado nas usinas termelétricas indicadas por ordem de mérito é plenamente intitulado como ordem de mérito.

REGIÃO SUDESTE/CENTRO-OESTE																	
Combustível	Combustível	CVU (R$/MWh)	Inflexibilidade			Ordem de Mérito			Total Mérito e INFL.			Razão Elétrica			Total UTE		
			P	M	L	P	M	L	P	M	L	P	M	L	P	M	L
ATLAN_CSA (255)	Resíduos	0,00	183,2	183,2	183,2				183,2	183,2	183,2				183,2	183,2	183,2
ANGRA 2 (1350)	Nuclear	20,12	1220,0	1220,0	1220,0	0,0	0,0	0,0	1220,0	1220,0	1220,0				1220,0	1220,0	1220,0
ANGRA 1 (640)	Nuclear	31,17	640,0	640,0	640,0	0,0	0,0	0,0	640,0	640,0	640,0				640,0	640,0	640,0
NORTEFLU 1 (400)	Gás	82,25	400,0	400,0	400,0	0,0	0,0	0,0	400,0	400,0	400,0				400,0	400,0	400,0
NORTEFLU 2 (100)	Gás	93,32	100,0	100,0	100,0	0,0	0,0	0,0	100,0	100,0	100,0				100,0	100,0	100,0
UTE STA VI (41)	Biomassa	116,91				38,5	38,5	38,5	38,5	38,5	38,5				38,5	38,5	38,5
BAIXADA FL (530)	Gás	129,20				520,0	520,0	520,0	520,0	520,0	520,0				520,0	520,0	520,0
SANTA CRUZ (500)	GNL	145,99															
NORTEFLU 3 (200)	Gás	179,16	200,0	200,0	200,0	0,0	0,0	0,0	200,0	200,0	200,0				200,0	200,0	200,0
ATLANTICO (235)	Resíduos	192,78	218,7	218,7	218,7	0,0	0,0	0,0	218,7	218,7	218,7				218,7	218,7	218,7
LUIZORMELO (204)	GNL	218,79										187,0	187,0	187,0	187,0	187,0	187,0
T.LAGOAS (350)	Gás	224,42				264,4	264,4	264,4	264,4	264,4	264,4				264,4	264,4	264,4
TERMORIO (1036)	Gás	267,70	155,0	155,0	155,0	735,0	735,0	735,0	890,0	890,0	890,0				890,0	890,0	890,0
JUIZ DE FO (87)	Gás	283,74				84,8	84,8	84,8	84,8	84,8	84,8				84,8	84,8	84,8
CUIABA CC (529)	Gás	309,71	490,0	490,0	490,0	0,0	0,0		490,0	490,0	490,0				490,0	490,0	490,0
ST.CRUZ 34 (436)	Óleo	310,41															
CUBATAO (216)	Gás	334,58	45,0	45,0	45,0				45,0	45,0	45,0				45,0	45,0	45,0
SEROPEDICA (386)	Gás	343,57															
IBIRITE (226)	Gás	346,37															
NORTEFLU 4 (127)	Gás	419,87	40,0	40,0	40,0				40,0	40,0	40,0				40,0	40,0	40,0
PIRAT.12 O (200)	Gás	470,34															
NPIRATINGA (572)	Gás	548,04															
VIANA (175)	Óleo	611,59															
T.MACAE (929)	Gás	612,01															
TNORTE 2 (340)	Óleo	910,86															
PALMEIR_GO (176)	Diesel	924,84															
IGARAPE (131)	Óleo	939,55															
CAMPOS (25)	Gás	978,10															
DAIA (44)	Diesel	1178,66															
GOIANIA 2 (140)	Diesel	1235,79															
XAVANTES (54)	Diesel	1695,17															
TOTAL SE/CO (10634)			3691,90	3691,90	3691,90	1642,7	1642,7	1642,7	5334,6	5334,6	5334,6	187,0	187,0	187,0	5521,6	5521,6	5521,6

REGIÃO SUL																	
Combustível	Combustível	CVU (R$/MWh)	Inflexibilidade			Ordem de Mérito			Total Mérito e INFL.			Razão Elétrica			Total UTE		
			P	M	L	P	M	L	P	M	L	P	M	L	P	M	L
PAMPA SUL (345)	Carvão	67,12				0,0	0,0	0,0	0,0	0,0	0,0				0,0	0,0	0,0
SAO SEPE (8)	Biomassa	84,44	5,0	5,0	5,0	0,0	0,0	0,0	5,0	5,0	5,0				5,0	5,0	5,0
CANDIOTA_3 (350)	Carvão	86,70				0,0	0,0	0,0	0,0	0,0	0,0				0,0	0,0	0,0
J.LACER. C (363)	Carvão	206,84	310,0	310,0	310,0	53,0	53,0	53,0	363,0	363,0	363,0				363,0	363,0	363,0
J.LACER. B (262)	Carvão	244,14	220,0	220,0	220,0	42,0	42,0	42,0	262,0	262,0	262,0				262,0	262,0	262,0
J.LAC. A2 (132)	Carvão	245,21	114,0	114,0	114,0	18,0	18,0	18,0	132,0	132,0	132,0				132,0	132,0	132,0
J.LAC. A1 (100)	Carvão	270,48	80,0	80,0	80,0	20,0	20,0	20,0	100,0	100,0	100,0				100,0	100,0	100,0
URUGUAIANA (640)	Gás	278,48															
MADEIRA (4)	Biomassa	310,67	2,0	2,0	2,0	1,0	1,0		3,0	3,0	2,0				3,0	3,0	2,0
FIGUEIRA (20)	Carvão	475,68															
ARAUCARIA (484)	Gás	630,54															
CANOAS (249)	Diesel	698,14															
TOTAL SUL (2957)			731,00	731,00	731,00	134,0	134,0	133,0	865,0	865,0	864,0	0,0	0,0	0,0	865,0	865,0	864,0

O conteúdo desta publicação foi produzido pelo ONS com base em dados e informações de conhecimento público. É de responsabilidade exclusiva dos agentes e demais interessados a obtenção de outros dados e informações, a realização de análises, estudos e avaliações para fins de tomada de decisões, definição de estratégias de atuação, assunção de compromissos e obrigações e quaisquer outras finalidades, em qualquer tempo e sob qualquer condição. É proibida a reprodução ou utilização total ou parcial do presente sem a identificação da fonte.

REGIÃO NORDESTE

Combustível	Combustível	CVU (R$/MWh)	Inflexibilidade			Ordem de Mérito			Total Mérito e INFL.			Razão Elétrica			Total UTE		
			P	M	L	P	M	L	P	M	L	P	M	L	P	M	L
PROSPERIDA (28)	Gás	159,37	28,0	28,0	28,0	0,0	0,0	0,0	28,0	28,0	28,0				28,0	28,0	28,0
TERMOPE (533)	Gás	160,86	532,7	532,7	532,7	0,0	0,0	0,0	532,7	532,7	532,7				532,7	532,7	532,7
P.PECEM1 (720)	Carvão	168,26				720,0	587,9		720,0	587,9					720,0	587,9	
P.PECEM2 (365)	Carvão	178,60				365,0			365,0						365,0		
PSERGIPE I (1516)	GNL	196,76															
FORTALEZA (327)	Gás	223,72															
VALE ACU (368)	Gás	321,65															
T.BAHIA (186)	Gás	323,11	95,0	95,0	95,0				95,0	95,0	95,0				95,0	95,0	95,0
T.CAMACARI (120)	Gás	345,02															
TERMOCEARA (223)	Gás	371,12															
SYKUE I (30)	Biomassa	510,12															
PERNAMBU_3 (201)	Óleo	519,86															
MARACANAU (168)	Óleo	590,30															
TERMOCABO (50)	Óleo	604,29															
TERMONE (171)	Óleo	609,68															
TERMOPB (171)	Óleo	609,68															
CAMPINA_GR (169)	Óleo	611,60															
SUAPE II (381)	Óleo	614,26															
GLOBAL I (149)	Óleo	694,11															
GLOBAL II (149)	Óleo	694,11															
BAHIA_1 (31)	Óleo	731,06															
ALTOS (13)	Diesel	1024,21															
ARACATI (11)	Diesel	1024,21															
BATURITE (11)	Diesel	1024,21															
C.MAIOR (13)	Diesel	1024,21															
CAUCAIA (15)	Diesel	1024,21															
CRATO (13)	Diesel	1024,21															
IGUATU (15)	Diesel	1024,21															
JUAZEIRO N (15)	Diesel	1024,21															
MARAMBAIA (13)	Diesel	1024,21															
NAZARIA (13)	Diesel	1024,21															
PECEM (15)	Diesel	1024,21															
AREMBEPE (150)	Óleo	1167,53															
MURICY (147)	Óleo	1167,53															
POTIGUAR_3 (66)	Diesel	1223,15															
POTIGUAR (53)	Diesel	1223,16															
PETROLINA (136)	Óleo	1280,95															
PAU FERRO (94)	Diesel	1379,56															
TERMOMANAU (143)	Diesel	1379,56															
TOTAL NE (6992)			655,70	655,70	655,70	1085,0	587,9	0,0	1740,7	1243,6	655,7	0,0	0,0	0,0	1740,7	1243,6	655,7

REGIÃO NORTE

Combustível	Combustível	CVU (R$/MWh)	Inflexibilidade			Ordem de Mérito			Total Mérito e INFL.			Razão Elétrica			Total UTE		
			P	M	L	P	M	L	P	M	L	P	M	L	P	M	L
C. ROCHA (85)	Gás	0,00	65,0	65,0	65,0				65,0	65,0	65,0				65,0	65,0	65,0
JARAQUI (75)	Gás	0,00	63,0	63,0	63,0				63,0	63,0	63,0				63,0	63,0	63,0
MANAUARA (67)	Gás	0,00	64,5	64,5	64,5				64,5	64,5	64,5				64,5	64,5	64,5
PONTA NEGR (66)	Gás	0,00	64,0	64,0	64,0				64,0	64,0	64,0				64,0	64,0	64,0
TAMBAQUI (93)	Gás	0,00	63,0	63,0	63,0				63,0	63,0	63,0				63,0	63,0	63,0
APARECIDA (166)	Gás	68,11	75,00	75,00	75,00	36,3	29,7	19,0	111,3	104,7	94,0				111,3	104,7	94,0
UTE MAUA 3 (591)	Gás	68,11	264,00	264,00	264,00	326,8	326,8	326,8	590,8	590,8	590,8				590,8	590,8	590,8
MARANHAO3 (519)	Gás	82,48	490,0	490,0	490,0	0,0	25,8	23,0	490,0	515,8	513,0				490,0	515,8	513,0
MARANHAO V (338)	Gás	135,77				325,0	336,3	335,1	325,0	336,3	335,1				325,0	336,3	335,1
MARANHAOIV (338)	Gás	135,77				325,0	336,3	335,1	325,0	336,3	335,1				325,0	336,3	335,1
PARNAIB_IV (56)	Gás	151,69				56,3	56,3	56,3	56,3	56,3	56,3				56,3	56,3	56,3
P. ITAQUI (360)	Carvão	173,07				360,1	360,1	360,1	360,1	360,1	360,1				360,1	360,1	360,1
N.VENECIA2 (270)	Gás	223,51				170,0	177,3	176,6	170,0	177,3	176,6				170,0	177,3	176,6
GERAMAR1 (166)	Óleo	611,58															
GERAMAR2 (166)	Óleo	611,58															
TOTAL NORTE (3356)			1148,5	1148,5	1148,5	1599,5	1648,6	1632,0	2748,0	2797,1	2780,5	0,0	0,0	0,0	2748,0	2797,1	2780,5

O conteúdo desta publicação foi produzido pelo ONS com base em dados e informações de conhecimento público. É de responsabilidade exclusiva dos agentes e demais interessados a obtenção de outros dados e informações, a realização de análises, estudos e avaliações para fins de tomada de decisões, definição de estratégias de atuação, assunção de compromissos e obrigações e quaisquer outras finalidades, em qualquer tempo e sob qualquer condição. É proibida a reprodução ou utilização total ou parcial do presente sem a identificação da fonte.