1. APRESENTAÇÃO

Na semana de 14/11 a 20/11/2020 ocorreu chuva fraca nas bacias dos rios Jacuí, Uruguai, Iguaçu, Paranapanema, Tietê, Grande, Paranaíba, Tocantins, Madeira e em pontos isolados do Xingu.

No início da semana de 21/11 a 27/11/2020 deve ocorrer chuva fraca nas bacias dos rios São Francisco, Tocantins, Xingu, no trecho brasileiro da bacia do rio Madeira e em pontos isolados do Paranaíba. E no final dessa semana deve ocorrer chuva fraca nas bacias dos rios Jacuí e Uruguai.

Para a semana operativa de 21/11 a 27/11/2020, houve oferta de energia da República Oriental do Uruguai e da República da Argentina. De acordo com o Art. 2º da Portaria MME nº 339, de 15 de agosto de 2018, as ofertas para importação de energia não foram consideradas na elaboração do PMO.

Os valores médios semanais do Custo Marginal de Operação – CMO dos subsistemas do SIN sofreram as seguintes alterações em relação à semana anterior:

- SE/CO: de R$ 475,62/MWh para R$ 617,02/MWh
- Sul: de R$ 475,62/MWh para R$ 617,02/MWh
- Nordeste: de R$ 244,33/MWh para R$ 189,40/MWh
- Norte: de R$ 475,62/MWh para R$ 617,02/MWh

Desde o dia 01/01/2020, o despacho por ordem de mérito é indicado diariamente pelos resultados do modelo DESSEM. Assim, o despacho por ordem de mérito semanal, conforme publicado nesse documento, tem caráter apenas informativo.

2. NOTÍCIAS

Nos dias 26 e 27 de novembro será realizada a reunião de elaboração do PMO Dezembro de 2020, com transmissão ao vivo através do site do ONS.

Como medida adicional de prevenção ao Coronavírus, o ONS informa que está suspensa, temporariamente, a participação presencial nas reuniões.

3. ANÁLISE DAS CONDIÇÕES HIDROMETEOROLÓGICAS

3.1. PREVISÃO PARA A PRÓXIMA SEMANA

A atuação da frente fria no litoral sul da Bahia no início da próxima semana ocasiona precipitação nas bacias dos rios São Francisco, Tocantins, Xingu, no trecho brasileiro da bacia do rio Madeira e em pontos isolados do Paranaíba. No final da semana uma nova frente fria avança pelo Rio Grande do Sul ocasionando chuva fraca nas bacias dos rios Jacuí e Uruguai **(Figura 1).**

O conteúdo desta publicação foi produzido pelo ONS com base em dados e informações de conhecimento público. É de responsabilidade exclusiva dos agentes e demais interessados a obtenção de outros dados e informações, a realização de análises, estudos e avaliações para fins de tomada de decisões, definição de estratégias de atuação, assunção de compromissos e obrigações e quaisquer outras finalidades, em qualquer tempo e sob qualquer condição. É proibida a reprodução ou utilização total ou parcial do presente sem a identificação da fonte.

Figura 1 - Precipitação acumulada prevista pelo modelo ECMWF (ECMWF) para o período de 21 a 27/11/2020

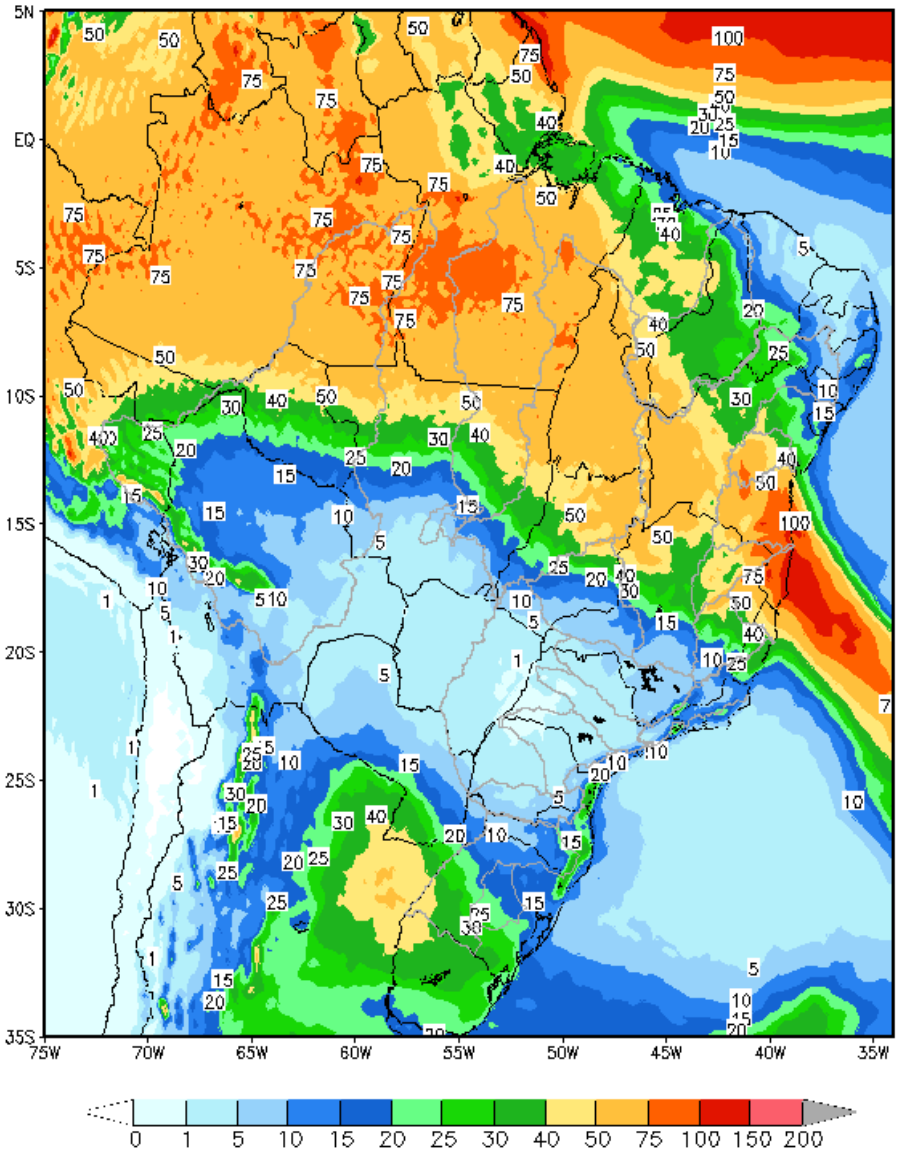

Em comparação com os valores estimados para a semana em curso, prevê-se para a próxima semana operativa recessão nas afluências dos subsistemas Sul e Nordeste e ascensão nas afluências dos subsistemas Sudeste e Norte. A previsão mensal para outubro indica a ocorrência de afluências abaixo da média histórica para todos os subsistemas.

Tabela 1 – Previsão de ENAs da revisão 3 de novembro/2020

Revisão 3 do PMO de Novembro/2020 - ENAs previstas				
Subsistema	21/11 a 27/11/2020		Mês de Novembro	
	MWmed	%MLT	MWmed	%MLT
SE/CO	19.356	61	18.511	59
S	2.051	22	1.994	21
NE	3.598	67	4.262	80
N	4.699	116	3.536	87

O conteúdo desta publicação foi produzido pelo ONS com base em dados e informações de conhecimento público. É de responsabilidade exclusiva dos agentes e demais interessados a obtenção de outros dados e informações, a realização de análises, estudos e avaliações para fins de tomada de decisões, definição de estratégias de atuação, assunção de compromissos e obrigações e quaisquer outras finalidades, em qualquer tempo e sob qualquer condição. É proibida a reprodução ou utilização total ou parcial do presente sem a identificação da fonte.

4. PREVISÃO DE CARGA

Os indicadores econômicos continuam mostrando sinais de expansão acentuada pós os efeitos ocorridos com as medidas restritivas de isolamento social. Merece destaque, o retorno do Nível de Utilização da Capacidade Instalada - NUCI, disponibilizado pela Fundação Getúlio Vargas - FGV, a um nível próximo da média anterior à pandemia. Outro fator importante foi o crescimento pelo segundo mês seguido, da atividade do setor de serviços no Brasil, segundo a pesquisa Índice de Gerentes de Compras (PMI na sigla em inglês).

As sinalizações meteorológicas indicam para próxima semana operativa a ocorrência de temperaturas médias semelhantes às observadas na semana em curso para as capitais dos subsistemas Sudeste/Centro-Oeste e Sul. Ressalta-se que somente Porto Alegre há expectativa de ocorrência de temperaturas médias superiores às verificas na semana atual.

As capitais dos subsistemas Nordeste e Norte, seguem com expectativa de manutenção do comportamento observado nas últimas semanas no que se refere às temperaturas e precipitação.

As taxas de crescimento previstas para o mês de novembro em relação ao mesmo mês de 2019, são de 1,0% no subsistema Sudeste/Centro-Oeste, 4,1% para o subsistema Sul, 3,1% no subsistema do Norte e um decréscimo de 1,0% no subsistema Nordeste.

O comportamento da carga durante a semana em curso no subsistema Norte foi impactado por dois fatores principais: a interrupção parcial do atendimento ao Amapá, em função de uma ocorrência no dia 03/11 na subestação que atende o Estado e também pelo retomada da carga dos consumidores livres da rede básica que apresentaram reduções na segunda semana operativa do mês.

No subsistema Nordeste, ressalta-se também que ocorreu a retomada de carga de um consumidor livre da rede básica que apresentava redução em sua carga desde a primeira semana operativa do mês em curso.

Tabela 2 – Evolução da carga do PMO de novembro/2020

Subsistema	CARGA SEMANAL (MWmed)					CARGA MENSAL (MWmed)	
	1ª Sem	2ª Sem	3ª Sem	4ª Sem	5ª Sem	nov/20	Var. (%) nov/20 -> nov/19
Sudeste	36.666	40.692	40.475	41.293	41.504	40.058	1,0%
Sul	11.247	12.530	12.790	12.961	12.959	12.478	4,1%
Nordeste	11.529	11.665	12.052	12.064	12.110	11.866	1,0%
Norte	5.762	5.779	5.969	6.095	6.204	5.936	3,1%
SIN	65.204	70.666	71.286	72.413	72.777	70.338	1,7%

O conteúdo desta publicação foi produzido pelo ONS com base em dados e informações de conhecimento público. É de responsabilidade exclusiva dos agentes e demais interessados a obtenção de outros dados e informações, a realização de análises, estudos e avaliações para fins de tomada de decisões, definição de estratégias de atuação, assunção de compromissos e obrigações e quaisquer outras finalidades, em qualquer tempo e sob qualquer condição. É proibida a reprodução ou utilização total ou parcial do presente sem a identificação da fonte.

5. PRINCIPAIS RESULTADOS

5.1. CUSTO MARGINAL DE OPERAÇÃO (CMO)

A tabela a seguir apresenta o CMO, por subsistema e patamar de carga para próxima semana operativa.

Tabela 3 – CMO por patamar de carga

Patamares de Carga	CMO (R$/MWh)			
	SE/CO	S	NE	N
Pesada	631,37	631,37	196,52	631,37
Média	631,37	631,37	188,25	631,37
Leve	601,96	601,96	186,58	601,96
Média Semanal	617,02	617,02	189,40	617,02

Na figura a seguir é apresentada a evolução do CMO médio semanal ao longo deste PMO.

Figura 2 – Evolução semanal do CMO

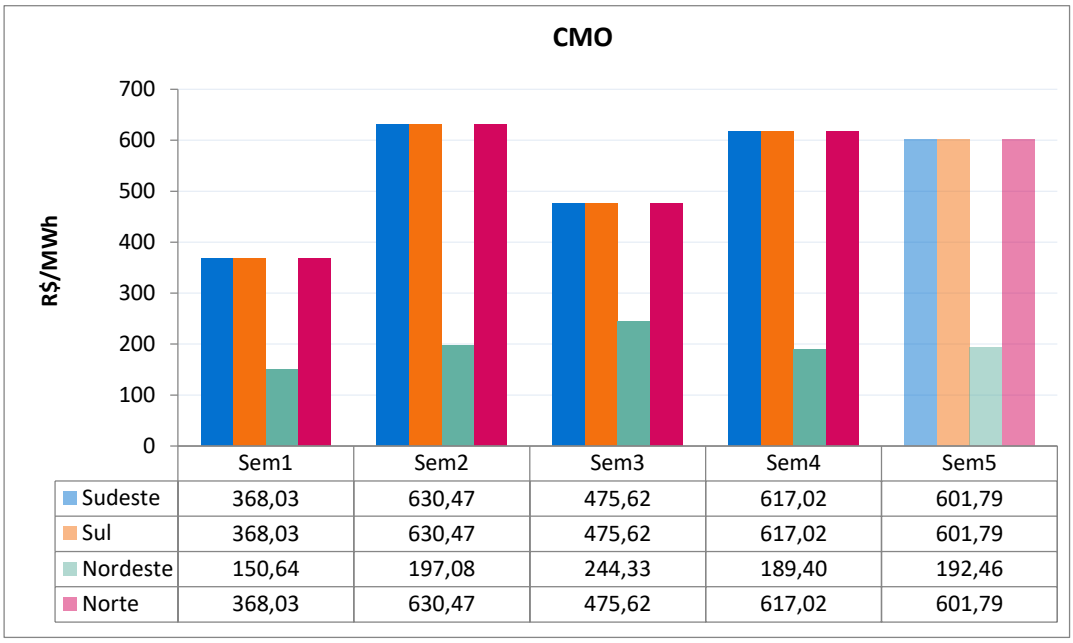

5.2. POLÍTICA DE OPERAÇÃO ENERGÉTICA

Para esta semana operativa, está prevista a seguinte política de intercâmbio de energia entre regiões:

Região SE/CO → Geração dimensionada para fechamento do balanço energético do SIN.

Região Sul → Predominantemente importador, respeitando-se os limites elétricos vigentes, tendo sua geração minimizada sempre que possível.

Região NE → Intercâmbio de energia definido em função dos recursos energéticos da região, buscando-se a máxima exploração, respeitando-se os limites elétricos vigentes para o subsistema.

Região Norte → Geração dimensionada de forma a otimizar os recursos desta região e buscando-se a aderência a curva guia para o armazenamento da UHE Tucuruí.

O conteúdo desta publicação foi produzido pelo ONS com base em dados e informações de conhecimento público. É de responsabilidade exclusiva dos agentes e demais interessados a obtenção de outros dados e informações, a realização de análises, estudos e avaliações para fins de tomada de decisões, definição de estratégias de atuação, assunção de compromissos e obrigações e quaisquer outras finalidades, em qualquer tempo e sob qualquer condição. É proibida a reprodução ou utilização total ou parcial do presente sem a identificação da fonte.

6. ANÁLISE DA VARIAÇÃO SEMANAL DO CMO

Esta análise visa identificar os principais parâmetros cujas atualizações impactaram os CMO desta revisão do PMO, em comparação com os valores obtidos na revisão anterior.

Foram realizados 8 estudos, onde caso inicial foi construído com base nos dados oficiais da última revisão deste PMO. Neste primeiro estudo a partida dos reservatórios foi estimada conforme indicado para esta semana na última revisão.

O segundo estudo foi realizado com os dados do caso inicial sendo substituída previsão de vazões para esta revisão.

A partir do conjunto de dados do segundo estudo foram elaborados os demais casos onde foram atualizados, sequencialmente, as seguintes informações: previsão de vazão, níveis de partida dos reservatórios, previsão de carga, disponibilidade das usinas, limites elétricos, restrições hidráulicas e por fim os demais dados que compõe toda a informação referente a atual revisão.

O principal fator que influenciou na elevação do CMO nos subsistemas do SE/CO, Sul e Norte foi a atualização da previsão de vazões.

Figura 3 – Análise da variação do CMO nos subsistemas SE/CO, Sul e Norte

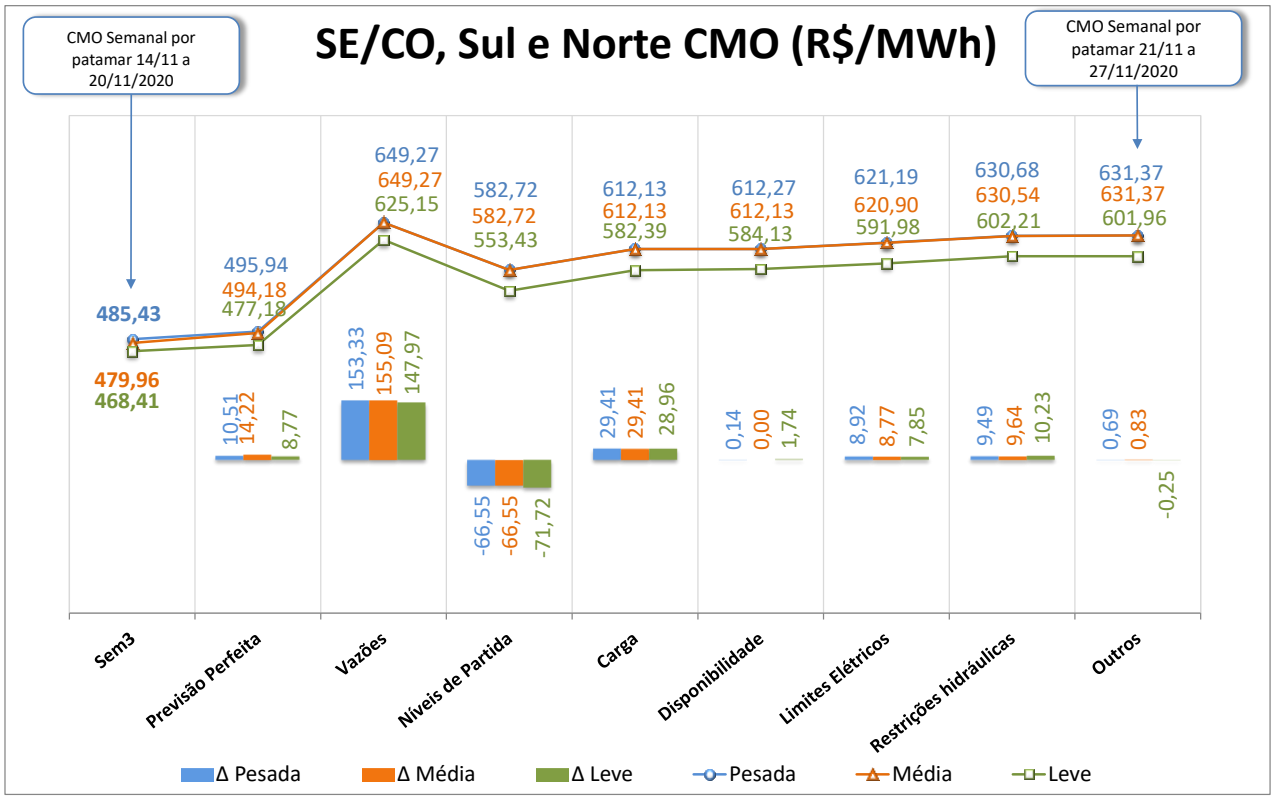

Os principais fatores que influenciaram na redução do CMO no subsistema do Nordeste foram as atualizações dos níveis de partida e disponibilidade das usinas, itens atualizados conforme prerrogativa dos agentes geradores, além da atualização da previsão de vazões.

O conteúdo desta publicação foi produzido pelo ONS com base em dados e informações de conhecimento público. É de responsabilidade exclusiva dos agentes e demais interessados a obtenção de outros dados e informações, a realização de análises, estudos e avaliações para fins de tomada de decisões, definição de estratégias de atuação, assunção de compromissos e obrigações e quaisquer outras finalidades, em qualquer tempo e sob qualquer condição. É proibida a reprodução ou utilização total ou parcial do presente sem a identificação da fonte.

Figura 4 – Análise da variação do CMO nos subsistemas Nordeste

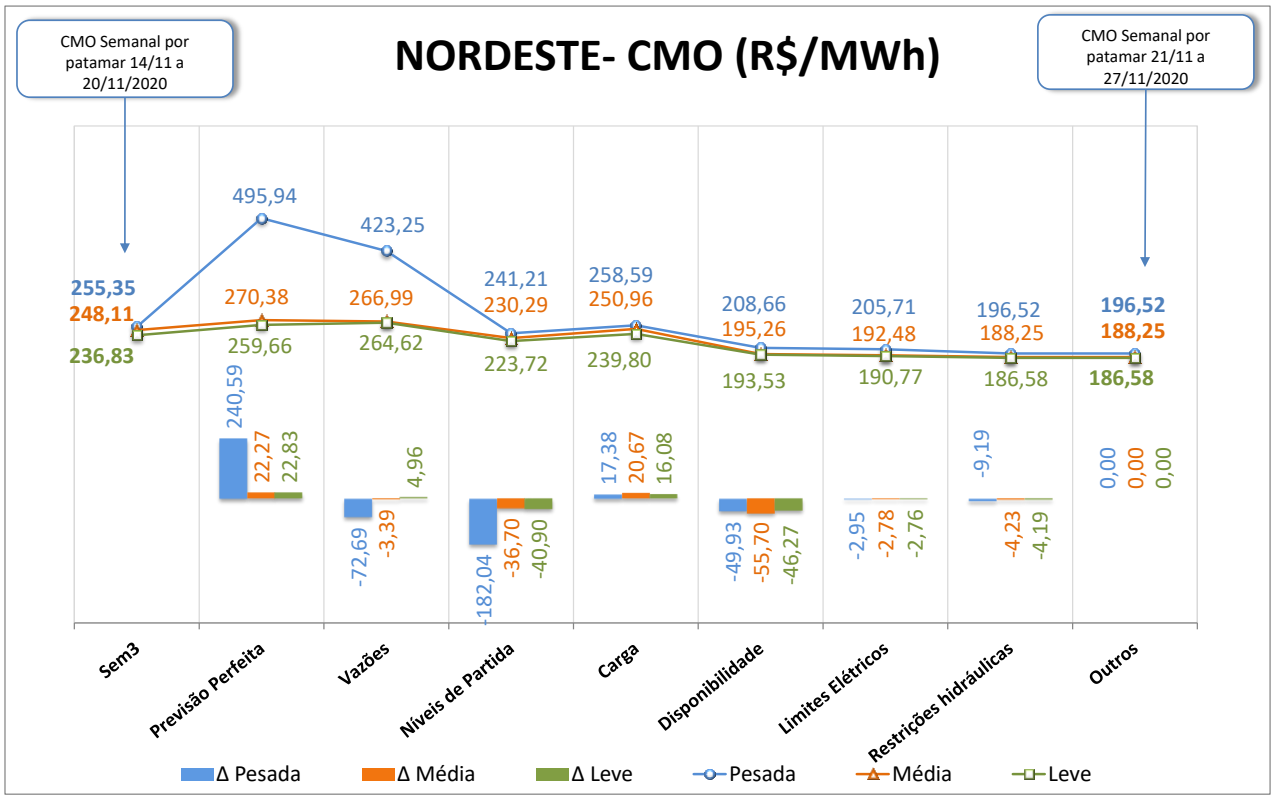

7. GERAÇÃO TÉRMICA

A Figura 5 apresenta, para cada subsistema, o despacho térmico por modalidade, para a próxima semana operativa.

Figura 5 – Geração térmica para a próxima semana operativa

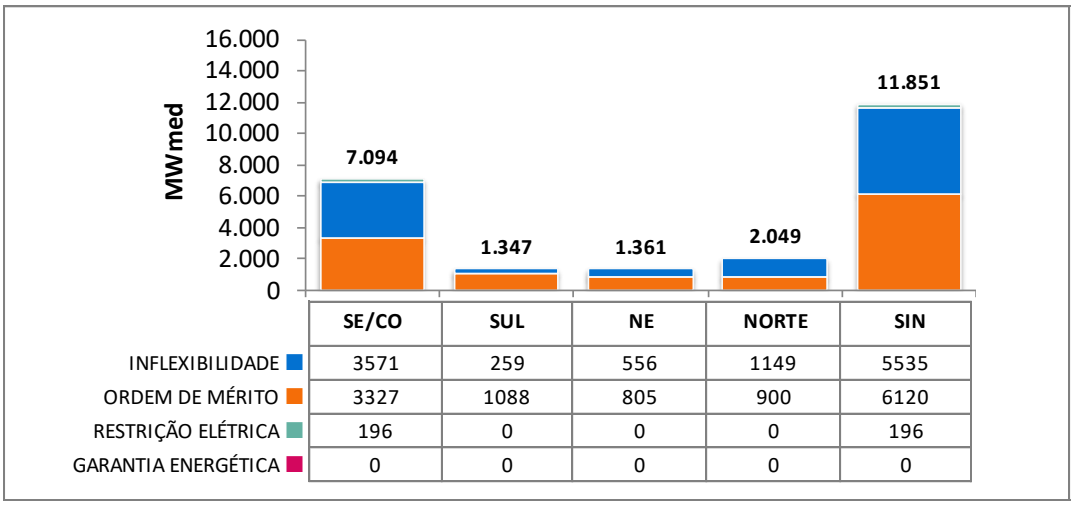

	SE/CO	SUL	NE	NORTE	SIN
INFLEXIBILIDADE	3571	259	556	1149	5535
ORDEM DE MÉRITO	3327	1088	805	900	6120
RESTRIÇÃO ELÉTRICA	196	0	0	0	196
GARANTIA ENERGÉTICA	0	0	0	0	0

Na tabela abaixo segue a Indicação de despacho antecipado por ordem de mérito de custo para a semana de 23/01/2021 a 29/01/2021.

O conteúdo desta publicação foi produzido pelo ONS com base em dados e informações de conhecimento público. É de responsabilidade exclusiva dos agentes e demais interessados a obtenção de outros dados e informações, a realização de análises, estudos e avaliações para fins de tomada de decisões, definição de estratégias de atuação, assunção de compromissos e obrigações e quaisquer outras finalidades, em qualquer tempo e sob qualquer condição. É proibida a reprodução ou utilização total ou parcial do presente sem a identificação da fonte.

Tabela 4 – UTEs com contrato de combustível GNL

UTE			Benefício (R$/MWh)		
Nome	Cod	CVU (R$/MWh)	Carga Pesada	Carga Média	Carga Leve
SANTA CRUZ	86	211,82	181,80 (2)	181,80 (2)	181,77 (2)
LUIZORMELO	15	323,32	181,80 (2)	181,80 (2)	181,77 (2)
PSERGIPE I	224	201,90	161,90 (2)	157,83 (2)	152,53 (2)

(1) Comandado o despacho antecipado por ordem de mérito de custo nesse patamar

(2) NÃO foi comandado o despacho antecipado por ordem de mérito de custo nesse patamar

Apesar da UTE Luiz O. R. Melo não estar despachada por ordem de mérito, há necessidade do despacho de, pelo menos, 204 MW dessa usina para reduzir o risco de corte de carga na região de Governador Valadares e na região Norte do Espírito Santo. Desta forma, a UTE Luiz O. R. Melo deverá ser despachada por razão elétrica, na referida semana, em 204 MW.

8. IMPORTAÇÃO DE ENERGIA DA REPÚBLICA ORIENTAL DO URUGUAI

8.1. República Oriental do Uruguai

Para a próxima semana operativa, foram declaradas as seguintes ofertas de importação de energia da República Oriental do Uruguai para o Sistema Interligado Nacional - SIN através das conversoras de Rivera (70 MW) e Melo (500 MW).

- **Eletrobras**

Tabela 5 – Energia Ofertada para Importação

	Oferta de Energia para a Semana de 21/11 a 27/11 (MWmed)				
	Bloco 1	Bloco 2	Bloco 3	Bloco 4	Total
Carga Pesada	60,0	90,0	50,0	85,0	285,0
Carga Média	60,0	90,0	50,0	85,0	285,0
Carga Leve	60,0	90,0	50,0	85,0	285,0
CVU (R$/MWh)	822,30	935,85	991,88	1085,59	

- **Enel**

Conforme declaração do agente, esta importação poderá ser realizada exclusivamente pela conversora Melo.

Tabela 6 – Energia Ofertada para Importação

	Oferta de Energia para a Semana de 21/11 a 27/11 (MWmed)				
	Bloco 1	Bloco 2	Bloco 3	Bloco 4	Total
Carga Pesada	60,0	90,0	50,0	85,0	285,0
Carga Média	60,0	90,0	50,0	85,0	285,0
Carga Leve	60,0	90,0	50,0	85,0	285,0
CVU (R$/MWh)	835,46	951,44	1008,84	1104,51	

O conteúdo desta publicação foi produzido pelo ONS com base em dados e informações de conhecimento público. É de responsabilidade exclusiva dos agentes e demais interessados a obtenção de outros dados e informações, a realização de análises, estudos e avaliações para fins de tomada de decisões, definição de estratégias de atuação, assunção de compromissos e obrigações e quaisquer outras finalidades, em qualquer tempo e sob qualquer condição. É proibida a reprodução ou utilização total ou parcial do presente sem a identificação da fonte.

8.2. República da Argentina

- **Enel**

Para a próxima semana operativa, foi declarada a seguinte oferta de importação de energia da República da Argentina para o SIN através das conversoras de Garabi 1 (1.100 MW) e Garabi 2 (1.100 MW).

Tabela 7 – Energia Ofertada para Importação

	Oferta de Energia para a Semana de 21/11 a 27/11 (MWmed)								
	Bloco 1	Bloco 2	Bloco 3	Bloco 4	Bloco 5	Bloco 6	Bloco 7	Bloco 8	Total
Carga Pesada	200,0	200,0	300,0	300,0	300,0	300,0	300,0	300,0	2200,0
Carga Média	200,0	200,0	300,0	300,0	300,0	300,0	300,0	300,0	2200,0
Carga Leve	200,0	200,0	300,0	300,0	300,0	300,0	300,0	300,0	2200,0
CVU (R$/MWh)	636,76	768,31	898,69	964,46	1030,23	1161,78	1293,32	1424,87	

Nota: Detalhes sobre a importação de energia vide Portaria Nº 339, de 15 de Agosto de 2018 disponível em: http://pesquisa.in.gov.br/imprensa/jsp/visualiza/index.jsp?data=17/08/2018&jornal=515&pagina=60&totalArquivos=136

9. ESTIMATIVA DE ENCARGOS OPERATIVOS

Para esta semana operativa não há estimativa de encargos operativos.

O conteúdo desta publicação foi produzido pelo ONS com base em dados e informações de conhecimento público. É de responsabilidade exclusiva dos agentes e demais interessados a obtenção de outros dados e informações, a realização de análises, estudos e avaliações para fins de tomada de decisões, definição de estratégias de atuação, assunção de compromissos e obrigações e quaisquer outras finalidades, em qualquer tempo e sob qualquer condição. É proibida a reprodução ou utilização total ou parcial do presente sem a identificação da fonte.

10. ARMAZENAMENTOS OPERATIVOS

Para uma melhor avaliação de diversos cenários hidrometeorológicos, notadamente, aqueles de curto prazo e suas influências nas previsões de vazões nos subsistemas, os resultados desta revisão do PMO contemplam cenários de afluências visando melhor representar a ocorrência de precipitação e, consequentemente, seus efeitos sobre as afluências e armazenamentos.

Além dos resultados associados ao valor esperado das previsões de afluências, as simulações operativas também foram realizadas com os limites superior e inferior das previsões de afluências. Apresentamos a seguir os resultados obtidos com a aplicação dos diferentes cenários de afluência.

Tabela 8 – Previsão de ENA dos cenários de sensibilidade

Subsistema	ENERGIAS NATURAIS AFLUENTES					
	Previsão Mensal					
	LI		VE		LS	
	(MWmed)	%MLT	(MWmed)	%MLT	(MWmed)	%MLT
Sudeste	16.448	**52**	18.511	**59**	20.620	**65**
Sul	1.594	**17**	1.994	**21**	2.469	**26**
Nordeste	3.893	**73**	4.262	**80**	4.625	**87**
Norte	3.188	**79**	3.536	**87**	3.883	**96**

Tabela 9 – Previsão de %EARmáx para o final do mês

Subsistema	% EARmáx 20/11	% EARmáx - 30/11		
	NÍVEL INICIAL	NÍVEL PMO		
	VE	LI	VE	LS
Sudeste	19,9	17,6	18,6	19,5
Sul	20,3	12,7	13,1	14,8
Nordeste	53,8	49,0	49,7	50,5
Norte	27,3	23,7	27,2	27,5

O conteúdo desta publicação foi produzido pelo ONS com base em dados e informações de conhecimento público. É de responsabilidade exclusiva dos agentes e demais interessados a obtenção de outros dados e informações, a realização de análises, estudos e avaliações para fins de tomada de decisões, definição de estratégias de atuação, assunção de compromissos e obrigações e quaisquer outras finalidades, em qualquer tempo e sob qualquer condição. É proibida a reprodução ou utilização total ou parcial do presente sem a identificação da fonte.

11. RESERVATÓRIOS EQUIVALENTES DE ENERGIA

A seguir são apresentadas as previsões de Energia Natural Afluente para a próxima semana operativa e para o mês de novembro, bem como as previsões de Energia Armazenada nos Reservatórios Equivalentes de Energia – REE, desta revisão do PMO.

Tabela 10 – Previsão de ENA por REE

Valor Esperado das Energias Naturais Afluentes				
REE	Previsão Semanal		Previsão Mensal	
	21/11/2020 a 27/11/2020		nov-20	
	(MWmed)	%MLT	(MWmed)	%MLT
Sudeste	4.797	95	4.343	86
Madeira	1.300	39	1.359	40
Teles Pires	699	51	714	52
Itaipu	2.167	70	2.054	66
Paraná	8.917	55	8.832	54
Paranapanema	1.443	61	1.179	49
Sul	678	15	839	18
Iguaçu	1.373	29	1.155	24
Nordeste	3.598	67	4.262	80
Norte	3.862	135	2.812	98
Belo Monte	586	60	423	43
Manaus	361	172	366	175

Tabela 11 – Previsão de %EARmáx por REE

% Energia Armazenável Máxima		
REE	Previsão Semanal	Previsão Mensal
	27-nov	30-nov
	(%EARmáx)	(%EARmáx)
Sudeste	26,4	26,2
Madeira	1,7	1,0
Teles Pires	14,1	8,1
Itaipu	11,0	6,3
Paraná	16,2	15,9
Paranapanema	19,6	20,0
Sul	23,3	21,7
Iguaçu	7,3	5,5
Nordeste	51,0	49,7
Norte	27,7	28,1
Belo Monte	98,3	97,5
Manaus	8,1	6,8

O conteúdo desta publicação foi produzido pelo ONS com base em dados e informações de conhecimento público. É de responsabilidade exclusiva dos agentes e demais interessados a obtenção de outros dados e informações, a realização de análises, estudos e avaliações para fins de tomada de decisões, definição de estratégias de atuação, assunção de compromissos e obrigações e quaisquer outras finalidades, em qualquer tempo e sob qualquer condição. É proibida a reprodução ou utilização total ou parcial do presente sem a identificação da fonte.

12. DESPACHO TÉRMICO POR MODALIDADE, PATAMAR DE CARGA E USINA

Nas tabelas abaixo, a diferenciação entre geração por inflexibilidade e por ordem de mérito tem caráter informativo, com o objetivo de detalhar a informação de inflexibilidade enviada pelos respectivos agentes para esta revisão do PMO. Ressalta-se que nas etapas de Programação Diária e Tempo Real, o montante despachado nas usinas termelétricas indicadas por ordem de mérito é plenamente intitulado como ordem de mérito.

REGIÃO SUDESTE/CENTRO-OESTE																	
Combustível	Combustível	CVU (R$/MWh)	Inflexibilidade			Ordem de Mérito			Total Mérito e INFL.			Razão Elétrica			Total UTE		
			P	M	L	P	M	L	P	M	L	P	M	L	P	M	L
ATLAN_CSA (255)	Resíduos	0,00	176,7	176,7	176,7				176,7	176,7	176,7				176,7	176,7	176,7
ANGRA 2 (1350)	Nuclear	20,12	1220,0	1220,0	1220,0	0,0	0,0	0,0	1220,0	1220,0	1220,0				1220,0	1220,0	1220,0
ANGRA 1 (640)	Nuclear	31,17	640,0	640,0	640,0	0,0	0,0	0,0	640,0	640,0	640,0				640,0	640,0	640,0
NORTEFLU 1 (400)	Gás	84,46	400,0	400,0	400,0	0,0	0,0	0,0	400,0	400,0	400,0				400,0	400,0	400,0
NORTEFLU 2 (100)	Gás	95,52	100,0	100,0	100,0	0,0	0,0	0,0	100,0	100,0	100,0				100,0	100,0	100,0
UTE STA VI (41)	Biomassa	120,46				36,0	36,0	36,0	36,0	36,0	36,0				36,0	36,0	36,0
NORTEFLU 3 (200)	Gás	183,45	200,0	200,0	200,0	0,0	0,0	0,0	200,0	200,0	200,0				200,0	200,0	200,0
BAIXADA FL (530)	Gás	187,49				520,0	520,0	520,0	520,0	520,0	520,0				520,0	520,0	520,0
ATLANTICO (235)	Resíduos	193,11	218,7	218,7	218,7	0,0	0,0	0,0	218,7	218,7	218,7				218,7	218,7	218,7
SANTA CRUZ (500)	GNL	211,82															
T.LAGOAS (350)	Gás	224,50				349,7	349,7	349,7	349,7	349,7	349,7				349,7	349,7	349,7
TERMORIO (1036)	Gás	267,82				710,0	710,0	710,0	710,0	710,0	710,0				710,0	710,0	710,0
JUIZ DE FO (87)	Gás	283,74				84,8	84,8	84,8	84,8	84,8	84,8				84,8	84,8	84,8
ST.CRUZ 34 (436)	Óleo	310,41				0,0	0,0	0,0									
LUIZORMELO (204)	GNL	323,32										196,0	196,0	196,0	196,0	196,0	196,0
CUBATAO (216)	Gás	335,30				209,0	209,0	209,0	209,0	209,0	209,0				209,0	209,0	209,0
SEROPEDICA (386)	Gás	343,69				350,0	350,0	350,0	350,0	350,0	350,0				350,0	350,0	350,0
IBIRITE (226)	Gás	346,37				222,0	222,0	222,0	222,0	222,0	222,0				222,0	222,0	222,0
NORTEFLU 4 (127)	Gás	386,94	126,0	126,0	126,0	0,0	0,0	0,0	126,0	126,0	126,0				126,0	126,0	126,0
CUIABA CC (529)	Gás	398,40	490,0	490,0	490,0	0,0	0,0	0,0	490,0	490,0	490,0				490,0	490,0	490,0
PIRAT.12 O (200)	Gás	470,34															
NPIRATINGA (572)	Gás	548,04				395,0	395,0	395,0	395,0	395,0	395,0				395,0	395,0	395,0
T.MACAE (929)	Gás	612,13				881,0	881,0		881,0	881,0					881,0	881,0	
VIANA (175)	Óleo	668,36															
PALMEIR_GO (176)	Diesel	889,29															
TNORTE 2 (340)	Óleo	910,86															
CAMPOS (25)	Gás	978,10															
DAIA (44)	Diesel	1178,79															
GOIANIA 2 (140)	Diesel	1235,94															
XAVANTES (54)	Diesel	1695,36															
TOTAL SE/CO (10503)			3571,40	3571,40	3571,40	3757,5	3757,5	2876,5	7328,9	7328,9	6447,9	196,0	196,0	196,0	7524,9	7524,9	6643,9

REGIÃO SUL																	
Combustível	Combustível	CVU (R$/MWh)	Inflexibilidade			Ordem de Mérito			Total Mérito e INFL.			Razão Elétrica			Total UTE		
			P	M	L	P	M	L	P	M	L	P	M	L	P	M	L
PAMPA SUL (345)	Carvão	69,15				0,0	0,0	0,0	0,0	0,0	0,0				0,0	0,0	0,0
CANDIOTA_3 (350)	Carvão	86,88	228,0	258,0	258,0	22,0	42,0	28,0	250,0	300,0	286,0				250,0	300,0	286,0
SAO SEPE (8)	Biomassa	87,00	6,5	6,5	6,5	0,0	0,0	0,0	6,5	6,5	6,5				6,5	6,5	6,5
J.LACER. C (363)	Carvão	206,84				363,0	363,0	363,0	363,0	363,0	363,0				363,0	363,0	363,0
J.LACER. B (262)	Carvão	244,14				262,0	262,0	262,0	262,0	262,0	262,0				262,0	262,0	262,0
J.LAC. A2 (132)	Carvão	245,21				132,0	132,0	132,0	132,0	132,0	132,0				132,0	132,0	132,0
J.LAC. A1 (100)	Carvão	270,48				100,0	100,0	100,0	100,0	100,0	100,0				100,0	100,0	100,0
URUGUAIANA (640)	Gás	278,48															
MADEIRA (4)	Biomassa	311,46	2,0	2,0	2,0	1,0	1,0	1,0	3,0	3,0	3,0				3,0	3,0	3,0
FIGUEIRA (20)	Carvão	475,68				0,0	0,0	0,0	0,0	0,0	0,0				0,0	0,0	0,0
ARAUCARIA (484)	Gás	630,54				360,0	416,0		360,0	416,0					360,0	416,0	
CANOAS (249)	Diesel	698,14															
TOTAL SUL (2957)			236,50	266,50	266,50	1240,0	1316,0	886,0	1476,5	1582,5	1152,5	0,0	0,0	0,0	1476,5	1582,5	1152,5

O conteúdo desta publicação foi produzido pelo ONS com base em dados e informações de conhecimento público. É de responsabilidade exclusiva dos agentes e demais interessados a obtenção de outros dados e informações, a realização de análises, estudos e avaliações para fins de tomada de decisões, definição de estratégias de atuação, assunção de compromissos e obrigações e quaisquer outras finalidades, em qualquer tempo e sob qualquer condição. É proibida a reprodução ou utilização total ou parcial do presente sem a identificação da fonte.

REGIÃO NORDESTE

Combustível	Combustível	CVU (R$/MWh)	Inflexibilidade			Ordem de Mérito			Total Mérito e INFL.			Razão Elétrica			Total UTE		
			P	M	L	P	M	L	P	M	L	P	M	L	P	M	L
PROSPERIDA (28)	Gás	164,20	22,4	24,0	24,0	0,0	0,0	0,0	22,4	24,0	24,0				22,4	24,0	24,0
TERMOPE (533)	Gás	180,57	532,7	532,7	532,7	0,0	0,0	0,0	532,7	532,7	532,7				532,7	532,7	532,7
P.PECEM1 (720)	Carvão	186,58				720,0	720,0	718,7	720,0	720,0	718,7				720,0	720,0	718,7
P.PECEM2 (365)	Carvão	196,52				361,4			361,4						361,4		
PSERGIPE I (1516)	GNL	201,90															
FORTALEZA (327)	Gás	223,72															
T.CAMACARI (120)	Gás	345,02															
TERMOCEARA (223)	Gás	371,29															
VALE ACU (368)	Gás	423,25															
T.BAHIA (186)	Gás	429,07															
SYKUE I (30)	Biomassa	510,12															
PERNAMBU_3 (201)	Óleo	569,58															
MARACANAU (168)	Óleo	646,00															
TERMOCABO (50)	Óleo	660,34															
TERMONE (171)	Óleo	665,61															
TERMOPB (171)	Óleo	665,61															
CAMPINA_GR (169)	Óleo	668,37															
SUAPE II (381)	Óleo	673,45															
BAHIA_1 (31)	Óleo	749,72															
GLOBAL I (149)	Óleo	758,31															
GLOBAL II (149)	Óleo	758,31															
ALTOS (13)	Diesel	1024,34															
ARACATI (11)	Diesel	1024,34															
BATURITE (11)	Diesel	1024,34															
C.MAIOR (13)	Diesel	1024,34															
CAUCAIA (15)	Diesel	1024,34															
CRATO (13)	Diesel	1024,34															
IGUATU (15)	Diesel	1024,34															
JUAZEIRO N (15)	Diesel	1024,34															
MARAMBAIA (13)	Diesel	1024,34															
NAZARIA (13)	Diesel	1024,34															
PECEM (15)	Diesel	1024,34															
AREMBEPE (150)	Óleo	1040,88															
MURICY (147)	Óleo	1040,88															
POTIGUAR_3 (66)	Diesel	1054,12															
POTIGUAR (53)	Diesel	1054,13															
PETROLINA (136)	Óleo	1142,00															
PAU FERRO (94)	Diesel	1192,17															
TERMOMANAU (143)	Diesel	1192,17															
TOTAL NE (6992)			555,10	556,70	556,70	1081,4	720,0	718,7	1636,5	1276,7	1275,4	0,0	0,0	0,0	1636,5	1276,7	1275,4

REGIÃO NORTE

Combustível	Combustível	CVU (R$/MWh)	Inflexibilidade			Ordem de Mérito			Total Mérito e INFL.			Razão Elétrica			Total UTE		
			P	M	L	P	M	L	P	M	L	P	M	L	P	M	L
C. ROCHA (85)	Gás	0,00	65,0	65,0	65,0				65,0	65,0	65,0				65,0	65,0	65,0
JARAQUI (75)	Gás	0,00	63,0	63,0	63,0				63,0	63,0	63,0				63,0	63,0	63,0
MANAUARA (67)	Gás	0,00	64,5	64,5	64,5				64,5	64,5	64,5				64,5	64,5	64,5
PONTA NEGR (66)	Gás	0,00	64,0	64,0	64,0				64,0	64,0	64,0				64,0	64,0	64,0
TAMBAQUI (93)	Gás	0,00	63,0	63,0	63,0				63,0	63,0	63,0				63,0	63,0	63,0
MARANHAO3 (519)	Gás	84,98	490,0	490,0	490,0	0,0	25,8	23,0	490,0	515,8	513,0				490,0	515,8	513,0
APARECIDA (166)	Gás	100,70	75,00	75,00	75,00	34,6	32,6	18,7	109,6	107,6	93,7				109,6	107,6	93,7
UTE MAUA 3 (591)	Gás	100,70	264,00	264,00	264,00	326,8	299,5	280,8	590,8	563,5	544,8				590,8	563,5	544,8
PARNAIB_IV (56)	Gás	151,69				56,3	56,3	56,3	56,3	56,3	56,3				56,3	56,3	56,3
P. ITAQUI (360)	Carvão	190,77				360,1	360,1	256,7	360,1	360,1	256,7				360,1	360,1	256,7
MARANHAO V (338)	Gás	195,26				325,0	137,8		325,0	137,8					325,0	137,8	
MARANHAOIV (338)	Gás	195,26				325,0	0,0		325,0	0,0					325,0	0,0	
N.VENECIA2 (270)	Gás	230,29															
GERAMAR1 (166)	Óleo	668,35															
GERAMAR2 (166)	Óleo	668,35															
TOTAL NORTE (3356)			1148,5	1148,5	1148,5	1427,8	912,1	635,5	2576,3	2060,6	1784,0	0,0	0,0	0,0	2576,3	2060,6	1784,0

O conteúdo desta publicação foi produzido pelo ONS com base em dados e informações de conhecimento público. É de responsabilidade exclusiva dos agentes e demais interessados a obtenção de outros dados e informações, a realização de análises, estudos e avaliações para fins de tomada de decisões, definição de estratégias de atuação, assunção de compromissos e obrigações e quaisquer outras finalidades, em qualquer tempo e sob qualquer condição. É proibida a reprodução ou utilização total ou parcial do presente sem a identificação da fonte.