1. APRESENTAÇÃO

Na semana de 30/01 a 05/02/2021 ocorreu chuva fraca à moderada nas bacias dos rios Jacuí, Uruguai, Iguaçu, Paranapanema e na incremental a UHE Itaipu. As bacias dos rios Tietê, Grande, Paranaíba, Tocantins, Xingu e Madeira apresentaram pancadas de chuva em pontos isolados no início da semana. No final da semana ocorreu chuva fraca nas bacias dos rios Tietê, Grande e no alto São Francisco.

Na semana de 06/02 a 12/02/2021 deve ocorrer precipitação nas bacias dos rios Tietê, Grande, Paranaíba, São Francisco, Tocantins, Xingu e Madeira.

Para a semana operativa de 06/02 a 12/02/2021, houve oferta de energia da República Oriental do Uruguai e da República da Argentina. De acordo com o Art. 2º da Portaria MME nº 339, de 15 de agosto de 2018, as ofertas para importação de energia não foram consideradas na elaboração do PMO.

Os valores médios semanais do Custo Marginal de Operação – CMO dos subsistemas do SIN sofreram as seguintes alterações em relação à semana anterior:

- SE/CO: de R$ 148,01/MWh para R$ 179,93/MWh
- Sul: de R$ 147,53/MWh para R$ 176,05/MWh
- Nordeste: de R$ 148,01/MWh para R$ 179,93/MWh
- Norte: de R$ 148,01/MWh para R$ 179,93/MWh

Desde o dia 01/01/2020, o despacho por ordem de mérito é indicado diariamente pelos resultados do modelo DESSEM. Assim, o despacho por ordem de mérito semanal, conforme publicado nesse documento, tem caráter apenas informativo. Da mesma forma, desde o dia 01/01/2021, a formação de preço deixou o formato semanal/patamar de carga e passou a ser horário, de acordo também com os resultados do modelo DESSEM.

2. NOTÍCIAS

Nos dias 25 e 26 de fevereiro será realizada a reunião de elaboração do PMO Março de 2021, com transmissão ao vivo através do site do ONS.

Como medida adicional de prevenção ao Coronavírus, o ONS informa que está suspensa, temporariamente, a participação presencial nas reuniões.

3. ANÁLISE DAS CONDIÇÕES HIDROMETEOROLÓGICAS

3.1. PREVISÃO PARA A PRÓXIMA SEMANA

O avanço da frente fria pelo norte do estado do Rio de Janeiro, Minas Gerais e Espírito Santo no início da próxima semana ocasiona precipitação nas bacias dos rios Tietê, Grande, Paranaíba, São Francisco, Tocantins, Xingu e Madeira (**Figura 1**).

O conteúdo desta publicação foi produzido pelo ONS com base em dados e informações de conhecimento público. É de responsabilidade exclusiva dos agentes e demais interessados a obtenção de outros dados e informações, a realização de análises, estudos e avaliações para fins de tomada de decisões, definição de estratégias de atuação, assunção de compromissos e obrigações e quaisquer outras finalidades, em qualquer tempo e sob qualquer condição. É proibida a reprodução ou utilização total ou parcial do presente sem a identificação da fonte.

Figura 1 - Precipitação acumulada prevista pelo modelo ECMWF (ECMWF) para o período de 06/02/2021 a 12/02/2021

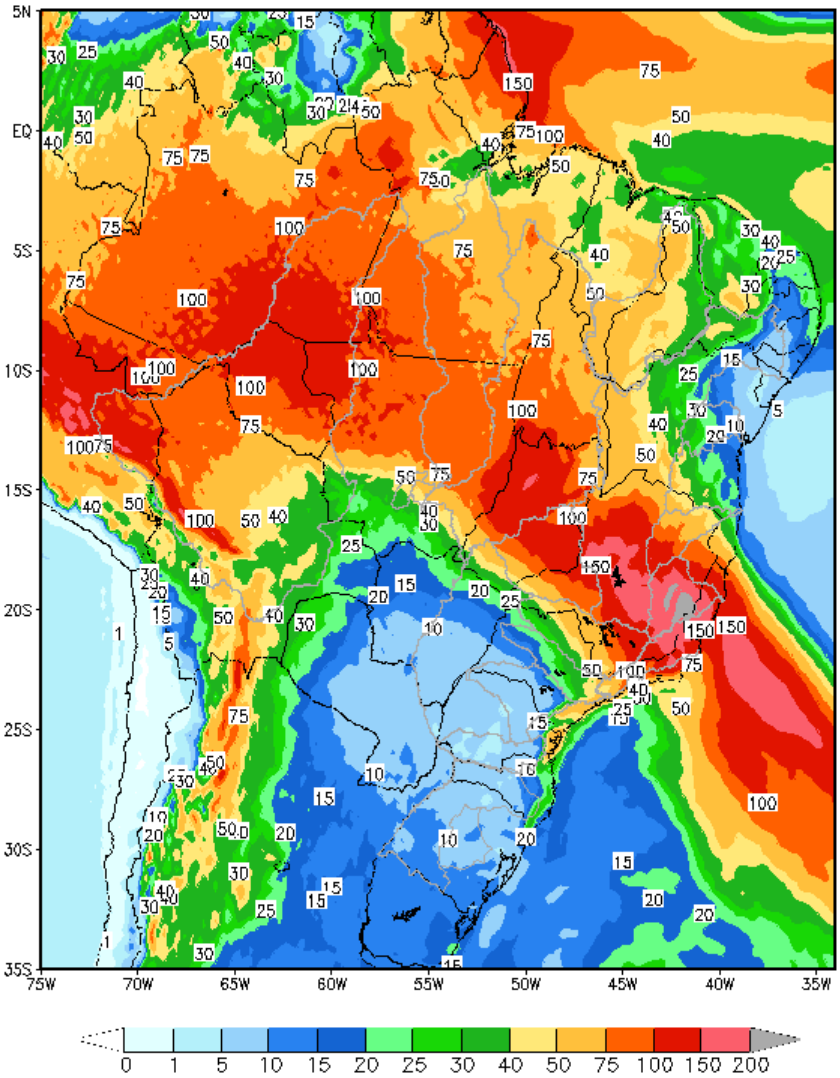

Em comparação com os valores estimados para a semana em curso, prevê-se para a próxima semana operativa ascensão nas afluências dos subsistemas Sudeste/Centro-Oeste e Norte e recessão nas afluências dos subsistemas Sul e Nordeste. A previsão mensal para fevereiro indica a ocorrência de afluências abaixo da média histórica para os subsistemas Sudeste/Centro-Oeste, Nordeste e Norte e acima da média histórica para o subsistema Sul.

O conteúdo desta publicação foi produzido pelo ONS com base em dados e informações de conhecimento público. É de responsabilidade exclusiva dos agentes e demais interessados a obtenção de outros dados e informações, a realização de análises, estudos e avaliações para fins de tomada de decisões, definição de estratégias de atuação, assunção de compromissos e obrigações e quaisquer outras finalidades, em qualquer tempo e sob qualquer condição. É proibida a reprodução ou utilização total ou parcial do presente sem a identificação da fonte.

Tabela 1 – Previsão de ENAs da Revisão 1 de Fevereiro/2021

Revisão 1 do PMO de Fevereiro/2021 - ENAs previstas				
Subsistema	06/02 a 12/02/2021		Mês de fevereiro	
	MWmed	%MLT	MWmed	%MLT
SE/CO	47.725	68	50.652	72
S	10.466	126	12.646	152
NE	3.682	26	4.422	31
N	11.346	50	13.275	58

4. PREVISÃO DE CARGA

A manutenção da trajetória de recuperação do setor industrial, associada à ocorrência de elevadas temperaturas, típicas para essa época do ano, justificam às taxas de crescimento apresentada pela carga do SIN.

As previsões de carga consolidadas para a próxima semana operativa levaram em consideração os fatos mencionados acima, além da expectativa de redução das temperaturas nas capitais das regiões Sudeste/Centro-Oeste e Sul, com exceção de Porto Alegre que deverá apresentar temperaturas, em média, semelhantes às registradas na semana atual. As capitais das regiões Nordeste e Norte seguem com previsão de manutenção de temperaturas elevadas, assim como o comportamento observado nas últimas semanas.

As taxas de crescimento previstas para o mês de fevereiro em relação ao mesmo mês de 2020, são de 3,2%, 0,2% e 2,1% para os subsistemas Sudeste/Centro-Oeste, Nordeste e Norte, respectivamente. Para o subsistema Sul é esperada uma variação negativa de 0,1% em relação ao mesmo mês do ano anterior.

Tabela 2 – Evolução da carga do PMO de Fevereiro/2021

Subsistema	CARGA SEMANAL (MWmed)					CARGA MENSAL (MWmed)	
	1ª Sem	2ª Sem	3ª Sem	4ª Sem	5ª Sem	fev/21	Var. (%) fev/21 -> fev/20
SE/CO	45.082	42.464	40.444	42.441	42.464	42.421	3,2%
Sul	13.054	12.980	12.853	13.376	13.389	13.090	-0,1%
Nordeste	11.521	11.563	11.063	11.656	11.683	11.462	0,2%
Norte	5.737	5.725	5.638	5.764	5.787	5.720	2,1%
SIN	75.394	72.732	69.998	73.237	73.323	72.693	2,0%

O conteúdo desta publicação foi produzido pelo ONS com base em dados e informações de conhecimento público. É de responsabilidade exclusiva dos agentes e demais interessados a obtenção de outros dados e informações, a realização de análises, estudos e avaliações para fins de tomada de decisões, definição de estratégias de atuação, assunção de compromissos e obrigações e quaisquer outras finalidades, em qualquer tempo e sob qualquer condição. É proibida a reprodução ou utilização total ou parcial do presente sem a identificação da fonte.

5. PRINCIPAIS RESULTADOS

5.1. CUSTO MARGINAL DE OPERAÇÃO (CMO)

A tabela a seguir apresenta o CMO, por subsistema e patamar de carga para próxima semana operativa.

Tabela 3 – CMO por patamar de carga

Patamares de Carga	CMO (R$/MWh)			
	SE/CO	S	NE	N
Pesada	184,34	180,21	184,34	184,34
Média	183,44	180,21	183,44	183,44
Leve	175,81	171,68	175,81	175,81
Média Semanal	179,93	176,05	179,93	179,93

Na figura a seguir é apresentada a evolução do CMO médio semanal ao longo deste PMO.

Figura 2 – Evolução semanal do CMO

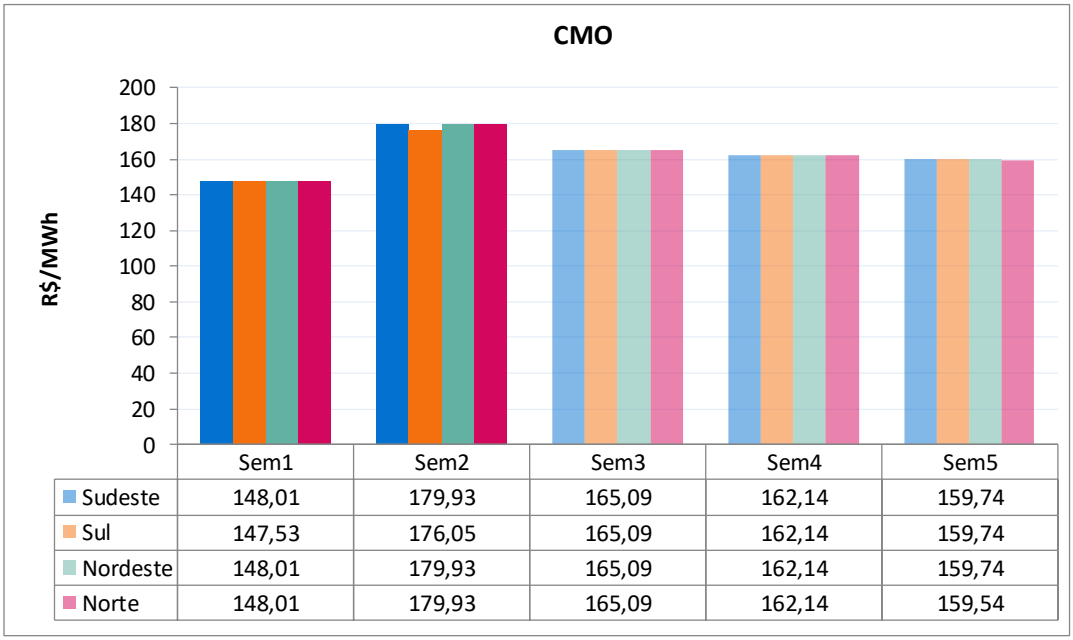

5.2. POLÍTICA DE OPERAÇÃO ENERGÉTICA

Para esta semana operativa, está prevista a seguinte política de intercâmbio de energia entre regiões:

Região SE/CO → Geração dimensionada para fechamento do balanço energético do SIN.

Região Sul → Geração hidráulica modulando em função dos recursos energéticos da região, com a exploração do intercâmbio de energia sempre que necessário, respeitando-se os limites elétricos vigentes.

Região NE → Redução da geração eólica e da exportação de energia, modulando em função dos recursos energéticos da região, respeitando-se os limites elétricos vigentes.

Região Norte → Aumento das disponibilidades energéticas e da sua exploração, respeitando-se os limites elétricos vigentes.

O conteúdo desta publicação foi produzido pelo ONS com base em dados e informações de conhecimento público. É de responsabilidade exclusiva dos agentes e demais interessados a obtenção de outros dados e informações, a realização de análises, estudos e avaliações para fins de tomada de decisões, definição de estratégias de atuação, assunção de compromissos e obrigações e quaisquer outras finalidades, em qualquer tempo e sob qualquer condição. É proibida a reprodução ou utilização total ou parcial do presente sem a identificação da fonte.

6. ANÁLISE DA VARIAÇÃO SEMANAL DO CMO

Esta análise visa identificar os principais parâmetros cujas atualizações impactaram os CMO desta revisão do PMO, em comparação com os valores obtidos na revisão anterior.

Foram realizados 7 estudos, onde o caso inicial foi construído com base nos dados oficiais da última revisão deste PMO. Neste primeiro estudo a partida dos reservatórios foi estimada conforme indicado para esta semana na última revisão. O segundo estudo foi realizado com os dados do caso inicial sendo substituída a previsão de vazões para esta revisão.

A partir do conjunto de dados do segundo estudo foram elaborados os demais casos em que foram atualizados, sequencialmente, as seguintes informações: níveis de partida dos reservatórios, previsão de carga, disponibilidades das usinas, limites elétricos, restrições hidráulicas e, por fim, os demais dados que compõem toda informação referente a atual revisão.

O principal fator que influenciou na elevação do CMO em todos os subsistemas do SIN foi a atualização da previsão de vazões.

Figura 3 – Análise da variação do CMO nos subsistemas SE/CO, NE e N

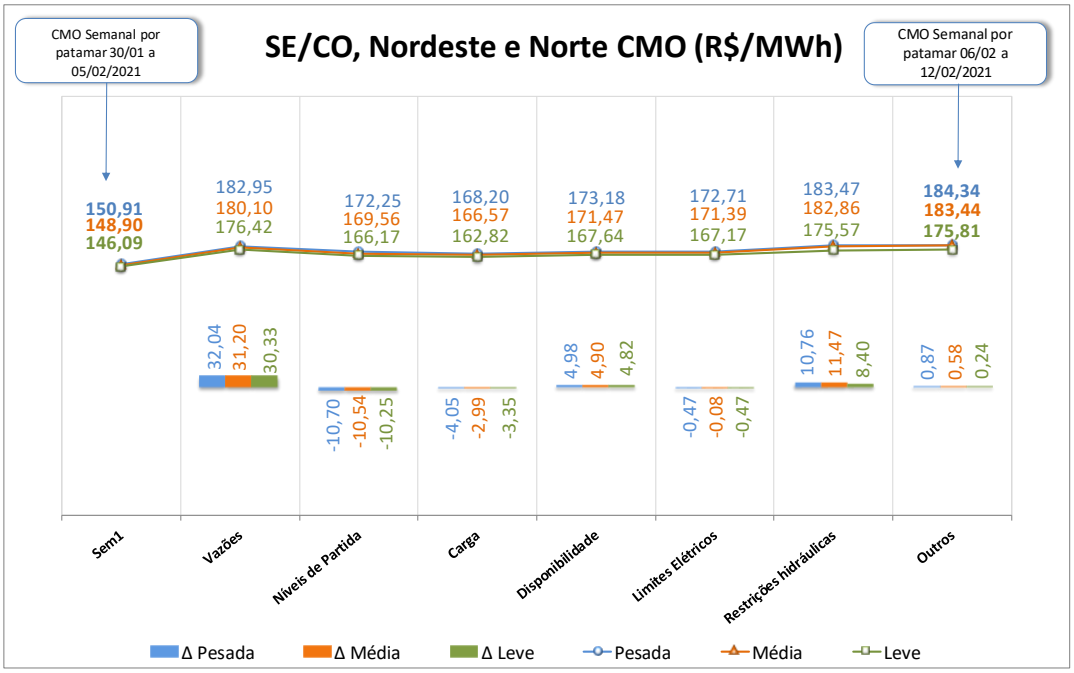

O conteúdo desta publicação foi produzido pelo ONS com base em dados e informações de conhecimento público. É de responsabilidade exclusiva dos agentes e demais interessados a obtenção de outros dados e informações, a realização de análises, estudos e avaliações para fins de tomada de decisões, definição de estratégias de atuação, assunção de compromissos e obrigações e quaisquer outras finalidades, em qualquer tempo e sob qualquer condição. É proibida a reprodução ou utilização total ou parcial do presente sem a identificação da fonte.

Figura 4 – Análise da variação do CMO no subsistema Sul

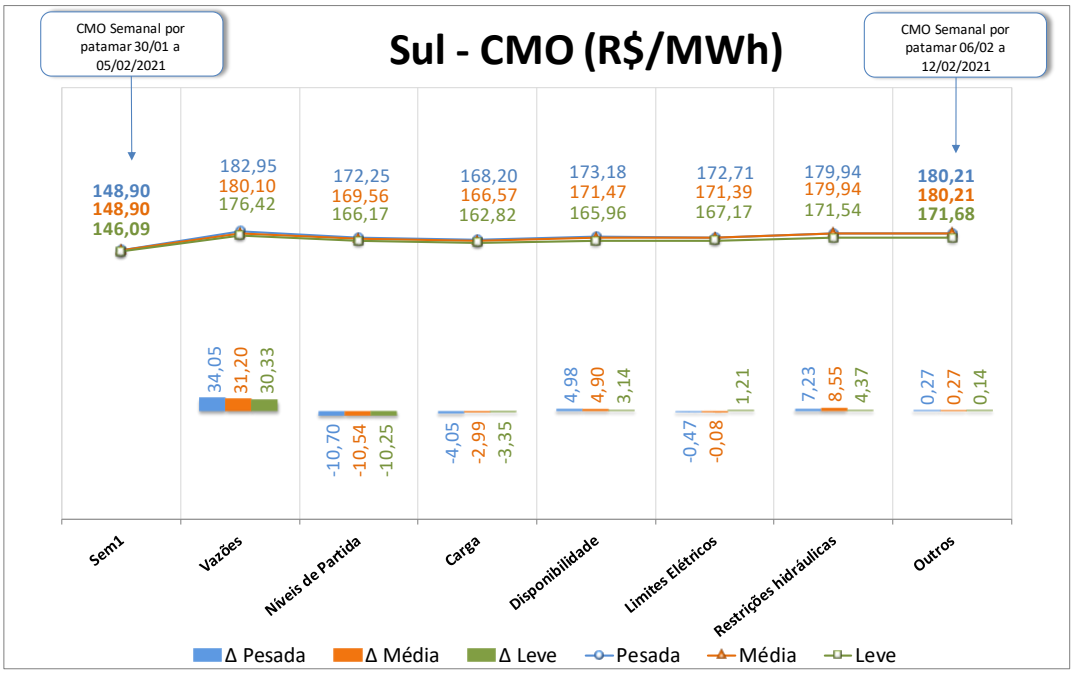

O conteúdo desta publicação foi produzido pelo ONS com base em dados e informações de conhecimento público. É de responsabilidade exclusiva dos agentes e demais interessados a obtenção de outros dados e informações, a realização de análises, estudos e avaliações para fins de tomada de decisões, definição de estratégias de atuação, assunção de compromissos e obrigações e quaisquer outras finalidades, em qualquer tempo e sob qualquer condição. É proibida a reprodução ou utilização total ou parcial do presente sem a identificação da fonte.

7. GERAÇÃO TÉRMICA

A Figura 5 apresenta, para cada subsistema, o despacho térmico por modalidade, para a próxima semana operativa.

Figura 5 – Geração térmica para a próxima semana operativa

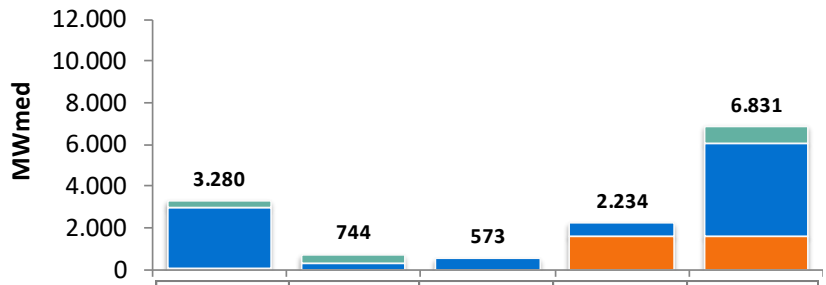

	SE/CO	SUL	NE	NORTE	SIN
INFLEXIBILIDADE	2922	334	565	658	4479
ORDEM DE MÉRITO	30	0	8	1576	1614
RESTRIÇÃO ELÉTRICA	328	410	0	0	738
GARANTIA ENERGÉTICA	0	0	0	0	0

Na tabela abaixo segue a Indicação de despacho antecipado por ordem de mérito de custo para a semana de 10/04/2021 a 16/04/2021.

Tabela 4 – UTEs com contrato de combustível GNL

UTE			Benefício (R$/MWh)		
Nome	Cod	CVU (R$/MWh)	Carga Pesada	Carga Média	Carga Leve
SANTA CRUZ	86	187,30	151,25 (2)	151,25 (2)	150,90 (2)
LUIZORMELO	15	284,10	151,25 (2)	151,25 (2)	150,90 (2)
PSERGIPE I	224	252,39	142,49 (2)	142,46 (2)	142,41 (2)

(1) Comandado o despacho antecipado por ordem de mérito de custo nesse patamar

(2) NÃO foi comandado o despacho antecipado por ordem de mérito de custo nesse patamar

Apesar da UTE Luiz O. R. Melo não estar despachada por ordem de mérito, há necessidade do despacho de, pelo menos, 204 MW dessa usina para reduzir o risco de corte de carga na região de Governador Valadares e na região Norte do Espírito Santo. Desta forma, a UTE Luiz O. R. Melo deverá ser despachada por razão elétrica, na referida semana, em 204 MW.

Ressalta-se que, embora a UTE Santa Cruz não esteja despachada antecipadamente por ordem de mérito de custo, o ONS comanda seu despacho antecipado, para a semana de 10/04 a 16/04/2021, por garantia energética.

O conteúdo desta publicação foi produzido pelo ONS com base em dados e informações de conhecimento público. É de responsabilidade exclusiva dos agentes e demais interessados a obtenção de outros dados e informações, a realização de análises, estudos e avaliações para fins de tomada de decisões, definição de estratégias de atuação, assunção de compromissos e obrigações e quaisquer outras finalidades, em qualquer tempo e sob qualquer condição. É proibida a reprodução ou utilização total ou parcial do presente sem a identificação da fonte.

8. IMPORTAÇÃO DE ENERGIA DA REPÚBLICA ORIENTAL DO URUGUAI

8.1. República Oriental do Uruguai

Para a próxima semana operativa, foram declaradas as seguintes ofertas de importação de energia da República Oriental do Uruguai para o Sistema Interligado Nacional - SIN através das conversoras de Rivera (70 MW) e Melo (500 MW).

- **Eletrobras**

Tabela 5 – Energia ofertada para importação

	Oferta de Energia para a Semana de 06/02 a 12/02 (MWmed)				
	Bloco 1	Bloco 2	Bloco 3	Bloco 4	Total
Carga Pesada	60	40	50	135	285
Carga Média	60	40	50	135	285
Carga Leve	60	40	50	135	285
CVU (R$/MWh)	317,40	415,75	548,75	759,25	

- **Enel**

Conforme declaração do agente, esta importação poderá ser realizada exclusivamente pela conversora Melo.

Tabela 6 – Energia ofertada para importação

	Oferta de Energia para a Semana de 06/02 a 12/02 (MWmed)				
	Bloco 1	Bloco 2	Bloco 3	Bloco 4	Total
Carga Pesada	60	40	50	135	285
Carga Média	60	40	50	135	285
Carga Leve	60	40	50	135	285
CVU (R$/MWh)	325,23	427,27	565,29	784,26	

8.2. República da Argentina

- **Enel**

Para a próxima semana operativa, foi declarada a seguinte oferta de importação de energia da República da Argentina para o SIN através das conversoras de Garabi 1 (1.100 MW) e Garabi 2 (1.100 MW).

Tabela 7 – Energia ofertada para importação

	Oferta de Energia para a Semana de 06/02 a 12/02 (MWmed)								
	Bloco 1	Bloco 2	Bloco 3	Bloco 4	Bloco 5	Bloco 6	Bloco 7	Bloco 8	Total
Carga Pesada	300	300	300	300	200	300	300	200	2.200
Carga Média	300	300	300	300	200	300	300	200	2.200
Carga Leve	300	300	300	300	200	300	300	200	2.200
CVU (R$/MWh)	399,47	497,13	562,24	627,35	693,61	822,67	1.213,31	1.279,58	

Nota: Detalhes sobre a importação de energia vide Portaria Nº 339, de 15 de agosto de 2018 disponível em: http://pesquisa.in.gov.br/imprensa/jsp/visualiza/index.jsp?data=17/08/2018&jornal=515&pagina=60&totalArquivos=136

O conteúdo desta publicação foi produzido pelo ONS com base em dados e informações de conhecimento público. É de responsabilidade exclusiva dos agentes e demais interessados a obtenção de outros dados e informações, a realização de análises, estudos e avaliações para fins de tomada de decisões, definição de estratégias de atuação, assunção de compromissos e obrigações e quaisquer outras finalidades, em qualquer tempo e sob qualquer condição. É proibida a reprodução ou utilização total ou parcial do presente sem a identificação da fonte.

9. ESTIMATIVA DE ENCARGOS OPERATIVOS

A tabela a seguir apresenta a expectativa do custo de despacho térmico por restrição elétrica para esta semana operativa.

Tabela 8 – Expectativa de custo de despacho térmico por Restrição Elétrica

UTE Potência Instalada (MW)	CVU (R$/MWh)	Geração (MWmed)			ESS ELÉTRICO
		Carga Pesada	Carga Média	Carga Leve	
LUIZORMELO (204)	R$ 284,10	196,0	196,0	196,0	**R$ 3.430.105,84**
VIANA (175)	R$ 806,83	174,0	162,7	93,4	**R$ 13.830.961,75**
TOTAL SE/CO					**R$ 17.261.067,59**

O conteúdo desta publicação foi produzido pelo ONS com base em dados e informações de conhecimento público. É de responsabilidade exclusiva dos agentes e demais interessados a obtenção de outros dados e informações, a realização de análises, estudos e avaliações para fins de tomada de decisões, definição de estratégias de atuação, assunção de compromissos e obrigações e quaisquer outras finalidades, em qualquer tempo e sob qualquer condição. É proibida a reprodução ou utilização total ou parcial do presente sem a identificação da fonte.

10. ARMAZENAMENTOS OPERATIVOS

Para uma melhor avaliação de diversos cenários hidrometeorológicos, notadamente, aqueles de curto prazo e suas influências nas previsões de vazões nos subsistemas, os resultados desta revisão do PMO contemplam cenários de afluências visando melhor representar a ocorrência de precipitação e, consequentemente, seus efeitos sobre as afluências e armazenamentos.

Além dos resultados associados ao valor esperado das previsões de afluências, as simulações operativas também foram realizadas com os limites superior e inferior das previsões de afluências. Apresentamos a seguir os resultados obtidos com a aplicação dos diferentes cenários de afluência.

Tabela 9 – Previsão de ENA dos cenários de sensibilidade

Subsistema	ENERGIAS NATURAIS AFLUENTES					
	Previsão Mensal					
	LI		VE		LS	
	(MWmed)	%MLT	(MWmed)	%MLT	(MWmed)	%MLT
Sudeste	41.067	**58**	50.652	**72**	60.378	**86**
Sul	9.614	**115**	12.646	**152**	15.682	**188**
Nordeste	3.677	**26**	4.422	**31**	5.197	**36**
Norte	10.942	**48**	13.275	**58**	15.607	**69**

Tabela 10 – Previsão de %EARmáx para o final do mês

Subsistema	% EARmáx 05/02	% EARmáx - 28/02		
	NÍVEL INICIAL	NÍVEL PMO		
	VE	LI	VE	LS
SE/CO	23,7	26,2	29,7	33,1
Sul	59,9	42,1	54,6	72,3
Nordeste	52,4	50,6	53,0	55,2
Norte	30,9	33,0	38,5	46,6

O conteúdo desta publicação foi produzido pelo ONS com base em dados e informações de conhecimento público. É de responsabilidade exclusiva dos agentes e demais interessados a obtenção de outros dados e informações, a realização de análises, estudos e avaliações para fins de tomada de decisões, definição de estratégias de atuação, assunção de compromissos e obrigações e quaisquer outras finalidades, em qualquer tempo e sob qualquer condição. É proibida a reprodução ou utilização total ou parcial do presente sem a identificação da fonte.

11. RESERVATÓRIOS EQUIVALENTES DE ENERGIA

A seguir são apresentadas as previsões de Energia Natural Afluente para a próxima semana operativa e para o mês de fevereiro, bem como as previsões de Energia Armazenada nos Reservatórios Equivalentes de Energia – REE, desta revisão do PMO.

Tabela 11 – Previsão de ENA por REE

Valor Esperado das Energias Naturais Afluentes				
REE	Previsão Semanal		Previsão Mensal	
	06/02/2021 a 12/02/2021		fev/21	
	(MWmed)	%MLT	(MWmed)	%MLT
Sudeste	5.540	54	5.591	54
Madeira	8.499	81	8.960	85
Teles Pires	2.547	67	2.675	70
Itaipu	6.629	165	6.725	168
Paraná	21.032	55	22.849	60
Paranapanema	2.088	55	2.412	64
Sul	3.501	90	5.010	128
Iguaçu	6.966	157	7.637	172
Nordeste	3.682	26	4.422	31
Norte	5.169	40	6.150	48
Belo Monte	4.783	53	5.843	65
Manaus	1.169	134	1.224	140

Tabela 12 – Previsão de %EARmáx por REE

% Energia Armazenável Máxima		
REE	Previsão Semanal	Previsão Mensal
	12-fev	28-fev
	(%EARmáx)	(%EARmáx)
Sudeste	27,8	30,1
Madeira	29,8	53,4
Teles Pires	53,3	43,5
Itaipu	51,7	100,0
Paraná	23,0	28,6
Paranapanema	30,1	35,8
Sul	41,3	34,1
Iguaçu	71,6	73,1
Nordeste	52,1	53,0
Norte	31,7	39,2
Belo Monte	65,8	61,0
Manaus	22,2	24,2

O conteúdo desta publicação foi produzido pelo ONS com base em dados e informações de conhecimento público. É de responsabilidade exclusiva dos agentes e demais interessados a obtenção de outros dados e informações, a realização de análises, estudos e avaliações para fins de tomada de decisões, definição de estratégias de atuação, assunção de compromissos e obrigações e quaisquer outras finalidades, em qualquer tempo e sob qualquer condição. É proibida a reprodução ou utilização total ou parcial do presente sem a identificação da fonte.

12. DESPACHO TÉRMICO POR MODALIDADE, PATAMAR DE CARGA E USINA

Nas tabelas abaixo, a diferenciação entre geração por inflexibilidade e por ordem de mérito tem caráter informativo, com o objetivo de detalhar a informação de inflexibilidade enviada pelos respectivos agentes para esta revisão do PMO. Ressalta-se que nas etapas de Programação Diária e Tempo Real, o montante despachado nas usinas termelétricas indicadas por ordem de mérito é plenamente intitulado como ordem de mérito.

REGIÃO SUDESTE/CENTRO-OESTE																	
Combustível	Combustível	CVU (R$/MWh)	Inflexibilidade			Ordem de Mérito			Total Mérito e INFL.			Razão Elétrica			Total UTE		
			P	M	L	P	M	L	P	M	L	P	M	L	P	M	L
ATLAN_CSA (255)	Resíduos	0,00	163,2	163,2	163,2				163,2	163,2	163,2				163,2	163,2	163,2
ANGRA 2 (1350)	Nuclear	20,12	1220,0	1220,0	1220,0	0,0	0,0	0,0	1220,0	1220,0	1220,0				1220,0	1220,0	1220,0
ANGRA 1 (640)	Nuclear	31,17	640,0	640,0	640,0	0,0	0,0	0,0	640,0	640,0	640,0				640,0	640,0	640,0
NORTEFLU 1 (400)	Gás	81,96	400,0	400,0	400,0	0,0	0,0	0,0	400,0	400,0	400,0				400,0	400,0	400,0
NORTEFLU 2 (100)	Gás	93,02	100,0	100,0	100,0	0,0	0,0	0,0	100,0	100,0	100,0				100,0	100,0	100,0
UTE STA VI (41)	Biomassa	121,49				0,0	0,0	0,0									
NORTEFLU 3 (200)	Gás	177,88	180,0	180,0	180,0	20,0	20,0		200,0	200,0	180,0				200,0	200,0	180,0
BAIXADA FL (530)	Gás	184,34				83,7			83,7						83,7		
SANTA CRUZ (500)	GNL	187,30															
ATLANTICO (235)	Resíduos	193,84	218,7	218,7	218,7				218,7	218,7	218,7				218,7	218,7	218,7
T.LAGOAS (350)	Gás	261,03															
JUIZ DE FO (87)	Gás	283,74															
LUIZORMELO (204)	GNL	284,10										196,0	196,0	196,0	196,0	196,0	196,0
ST.CRUZ 34 (436)	Óleo	310,41															
TERMORIO (1036)	Gás	327,36															
CUBATAO (216)	Gás	336,01															
SEROPEDICA (386)	Gás	408,38															
NORTEFLU 4 (127)	Gás	437,66															
PIRAT.12 O (200)	Gás	470,34															
NPIRATINGA (572)	Gás	548,04															
CUIABA CC (529)	Gás	559,74															
T.MACAE (929)	Gás	735,42															
PALMEIR_GO (176)	Diesel	761,08															
VIANA (175)	Óleo	806,83										174,0	162,7	93,4	174,0	162,7	93,4
TNORTE 2 (340)	Óleo	910,86															
GOIANIA 2 (140)	Diesel	943,31															
IBIRITE (226)	Gás	971,27															
CAMPOS (25)	Gás	978,10															
DAIA (44)	Diesel	1017,02															
XAVANTES (54)	Diesel	1461,57															
TOTAL SE/CO (10503)			2921,90	2921,90	2921,90	103,7	20,0	0,0	3025,6	2941,9	2921,9	370,0	358,7	289,4	3395,6	3300,6	3211,3

REGIÃO SUL																	
Combustível	Combustível	CVU (R$/MWh)	Inflexibilidade			Ordem de Mérito			Total Mérito e INFL.			Razão Elétrica			Total UTE		
			P	M	L	P	M	L	P	M	L	P	M	L	P	M	L
PAMPA SUL (345)	Carvão	69,75				0,0	0,0	0,0	0,0	0,0	0,0				0,0	0,0	0,0
CANDIOTA_3 (350)	Carvão	87,07	325,0	325,0	325,0	0,0	0,0	0,0	325,0	325,0	325,0				325,0	325,0	325,0
SAO SEPE (8)	Biomassa	87,75	7,0	7,0	7,0	0,0	0,0	0,0	7,0	7,0	7,0				7,0	7,0	7,0
J.LACER. C (363)	Carvão	206,84										180,0	180,0	180,0	180,0	180,0	180,0
J.LACER. B (262)	Carvão	244,14										160,0	160,0	160,0	160,0	160,0	160,0
J.LAC. A2 (132)	Carvão	245,21										70,0	70,0	70,0	70,0	70,0	70,0
J.LAC. A1 (100)	Carvão	270,48															
MADEIRA (4)	Biomassa	311,72	2,0	2,0	2,0				2,0	2,0	2,0				2,0	2,0	2,0
ARAUCARIA (484)	Gás	468,39															
FIGUEIRA (20)	Carvão	475,68															
URUGUAIANA (640)	Gás	606,28															
CANOAS (249)	Diesel	698,14															
TOTAL SUL (2957)			334,00	334,00	334,00	0,0	0,0	0,0	334,0	334,0	334,0	410,0	410,0	410,0	744,0	744,0	744,0

O conteúdo desta publicação foi produzido pelo ONS com base em dados e informações de conhecimento público. É de responsabilidade exclusiva dos agentes e demais interessados a obtenção de outros dados e informações, a realização de análises, estudos e avaliações para fins de tomada de decisões, definição de estratégias de atuação, assunção de compromissos e obrigações e quaisquer outras finalidades, em qualquer tempo e sob qualquer condição. É proibida a reprodução ou utilização total ou parcial do presente sem a identificação da fonte.

REGIÃO NORDESTE

Combustível	Combustível	CVU (R$/MWh)	Inflexibilidade			Ordem de Mérito			Total Mérito e INFL.			Razão Elétrica			Total UTE		
			P	M	L	P	M	L	P	M	L	P	M	L	P	M	L
ERB CANDEI (17)	Biomassa	87,81	4,5	4,5	4,5	8,5	8,5	8,5	13,0	13,0	13,0				13,0	13,0	13,0
TERMOPE (533)	Gás	152,94	532,7	532,7	532,7	0,0	0,0	0,0	532,7	532,7	532,7				532,7	532,7	532,7
PROSPERIDA (28)	Gás	165,61	28,0	28,0	27,2	0,0	0,0	0,0	28,0	28,0	27,2				28,0	28,0	27,2
P.PECEM1 (720)	Carvão	211,32															
P.PECEM2 (365)	Carvão	220,12															
FORTALEZA (327)	Gás	223,72															
PSERGIPE I (1516)	GNL	252,39															
T.CAMACARI (120)	Gás	345,02															
TERMOCEARA (223)	Gás	427,83															
SYKUE I (30)	Biomassa	510,12															
PERNAMBU_3 (201)	Óleo	612,97															
MARACANAU (168)	Óleo	694,40															
CAMPINA_GR (169)	Óleo	717,45															
TERMOCABO (50)	Óleo	797,02															
TERMONE (171)	Óleo	801,37															
TERMOPB (171)	Óleo	801,37															
BAHIA_1 (31)	Óleo	815,31															
SUAPE II (381)	Óleo	820,10															
ALTOS (13)	Diesel	881,41															
ARACATI (11)	Diesel	881,41															
BATURITE (11)	Diesel	881,41															
C.MAIOR (13)	Diesel	881,41															
CAUCAIA (15)	Diesel	881,41															
CRATO (13)	Diesel	881,41															
IGUATU (15)	Diesel	881,41															
JUAZEIRO N (15)	Diesel	881,41															
MARAMBAIA (13)	Diesel	881,41															
NAZARIA (13)	Diesel	881,41															
PECEM (15)	Diesel	881,41															
GLOBAL I (149)	Óleo	914,67															
GLOBAL II (149)	Óleo	914,67															
POTIGUAR_3 (66)	Diesel	1000,83															
POTIGUAR (53)	Diesel	1000,84															
AREMBEPE (150)	Óleo	1019,02															
MURICY (147)	Óleo	1019,02															
VALE ACU (368)	Gás	1021,39															
T.BAHIA (186)	Gás	1055,14															
PETROLINA (136)	Óleo	1118,01															
PAU FERRO (94)	Diesel	1133,08															
TERMOMANAU (143)	Diesel	1133,08															
TOTAL NE (7009)			565,20	565,20	564,40	8,5	8,5	8,5	573,7	573,7	572,9	0,0	0,0	0,0	573,7	573,7	572,9

REGIÃO NORTE

Combustível	Combustível	CVU (R$/MWh)	Inflexibilidade			Ordem de Mérito			Total Mérito e INFL.			Razão Elétrica			Total UTE		
			P	M	L	P	M	L	P	M	L	P	M	L	P	M	L
GERAMAR2 (166)	Óleo	806,81															
GERAMAR1 (166)	Óleo	806,81															
PARNAIB_IV (56)	Gás	151,69				37,5	37,5	37,5	37,5	37,5	37,5				37,5	37,5	37,5
UTE MAUA 3 (591)	Gás	82,15	264,0	264,0	264,0	326,8	326,8	326,8	590,8	590,8	590,8				590,8	590,8	590,8
P. ITAQUI (360)	Carvão	214,21															
APARECIDA (166)	Gás	82,15	75,0	75,0	75,0	39,0	40,2	34,5	114,0	115,2	109,5				114,0	115,2	109,5
C. ROCHA (85)	Gás	0,00	65,0	65,0	65,0				65,0	65,0	65,0				65,0	65,0	65,0
JARAQUI (75)	Gás	0,00	63,0	63,0	63,0				63,0	63,0	63,0				63,0	63,0	63,0
MANAUARA (67)	Gás	0,00	64,5	64,5	64,5				64,5	64,5	64,5				64,5	64,5	64,5
PONTA NEGR (66)	Gás	0,00	64,0	64,0	64,0				64,0	64,0	64,0				64,0	64,0	64,0
TAMBAQUI (93)	Gás	0,00	63,0	63,0	63,0				63,0	63,0	63,0				63,0	63,0	63,0
MARANHAO3 (519)	Gás	85,72				490,0	515,8	513,0	490,0	515,8	513,0				490,0	515,8	513,0
MARAN_VL22 (1)	Gás	173,18				1,1	1,1	1,1	1,1	1,1	1,1				1,1	1,1	1,1
MARAN_VL_7 (336)	Gás	173,18				323,9	335,1	333,9	323,9	335,1	333,9				323,9	335,1	333,9
MARANIVL22 (1)	Gás	173,18				1,1	1,1	1,1	1,1	1,1	1,1				1,1	1,1	1,1
MARANIVL_7 (336)	Gás	173,18				323,8	335,1	333,9	323,8	335,1	333,9				323,8	335,1	333,9
N.VEN2_L22 (27)	Gás	232,01															
N.VEN2_L7 (151)	Gás	232,27															
TOTAL NORTE (3264)			658,5	658,5	658,5	1543,2	1592,7	1581,8	2201,7	2251,2	2240,3	0,0	0,0	0,0	2201,7	2251,2	2240,3

O conteúdo desta publicação foi produzido pelo ONS com base em dados e informações de conhecimento público. É de responsabilidade exclusiva dos agentes e demais interessados a obtenção de outros dados e informações, a realização de análises, estudos e avaliações para fins de tomada de decisões, definição de estratégias de atuação, assunção de compromissos e obrigações e quaisquer outras finalidades, em qualquer tempo e sob qualquer condição. É proibida a reprodução ou utilização total ou parcial do presente sem a identificação da fonte.