1. APRESENTAÇÃO

Na semana de 17/04 a 23/04/2021 ocorreu chuva fraca isolada nas bacias dos rios Uruguai e Paranapanema assim como nas bacias dos rios Tiete, Grande, Tocantins, no trecho médio e baixo do São Francisco, Xingu e do Madeira e em pontos isolados do Paranaíba.

Na semana de 24/04 a 30/04/2021 deve ocorrer precipitação nas bacias dos rios São Francisco, Tocantins, Xingu e Madeira, além de chuvisco/chuva fraca nas bacias dos rios Jacuí, Uruguai e Iguaçu.

Para a semana operativa de 24/04 a 30/04/2021, houve oferta de energia da República Oriental do Uruguai e da República da Argentina. De acordo com o Art. 2º da Portaria MME nº 339, de 15 de agosto de 2018, as ofertas para importação de energia não foram consideradas na elaboração do PMO.

Os valores médios semanais do Custo Marginal de Operação – CMO dos subsistemas do SIN sofreram as seguintes alterações em relação à semana anterior:

- SE/CO: de R$ 164,90/MWh para R$ 162,29/MWh
- Sul: de R$ 164,90/MWh para R$ 162,29/MWh
- Nordeste: de R$ 142,41/MWh para R$ 143,75/MWh
- Norte: de R$ 142,41/MWh para R$ 143,75/MWh

Desde o dia 01/01/2020, o despacho por ordem de mérito é indicado diariamente pelos resultados do modelo DESSEM. Assim, o despacho por ordem de mérito semanal, conforme publicado nesse documento, tem caráter apenas informativo. Da mesma forma, desde o dia 01/01/2021, a formação de preço deixou o formato semanal/patamar de carga e passou a ser horário, de acordo também com os resultados do modelo DESSEM.

2. NOTÍCIAS

Nos dias 29 e 30 de abril será realizada a reunião de elaboração do PMO Maio de 2021, com transmissão ao vivo através do site do ONS.

Como medida adicional de prevenção ao Coronavírus, o ONS informa que está suspensa, temporariamente, a participação presencial nas reuniões.

O conteúdo desta publicação foi produzido pelo ONS com base em dados e informações de conhecimento público. É de responsabilidade exclusiva dos agentes e demais interessados a obtenção de outros dados e informações, a realização de análises, estudos e avaliações para fins de tomada de decisões, definição de estratégias de atuação, assunção de compromissos e obrigações e quaisquer outras finalidades, em qualquer tempo e sob qualquer condição. É proibida a reprodução ou utilização total ou parcial do presente sem a identificação da fonte.

3. ANÁLISE DAS CONDIÇÕES HIDROMETEOROLÓGICAS

3.1. PREVISÃO PARA A PRÓXIMA SEMANA

No início da próxima semana permanece a condição de precipitação nas bacias dos rios São Francisco, Tocantins, Xingu e Madeira (**Figura 2**). Na região Sul uma nova frente fria avança rapidamente ocasionando chuvisco/chuva fraca nas bacias dos rios Jacuí, Uruguai e Iguaçu.

Figura 1- Precipitação acumulada prevista pelo modelo ECMWF (ECMWF) para o período de 24/04/2021 a 30/04/2021.

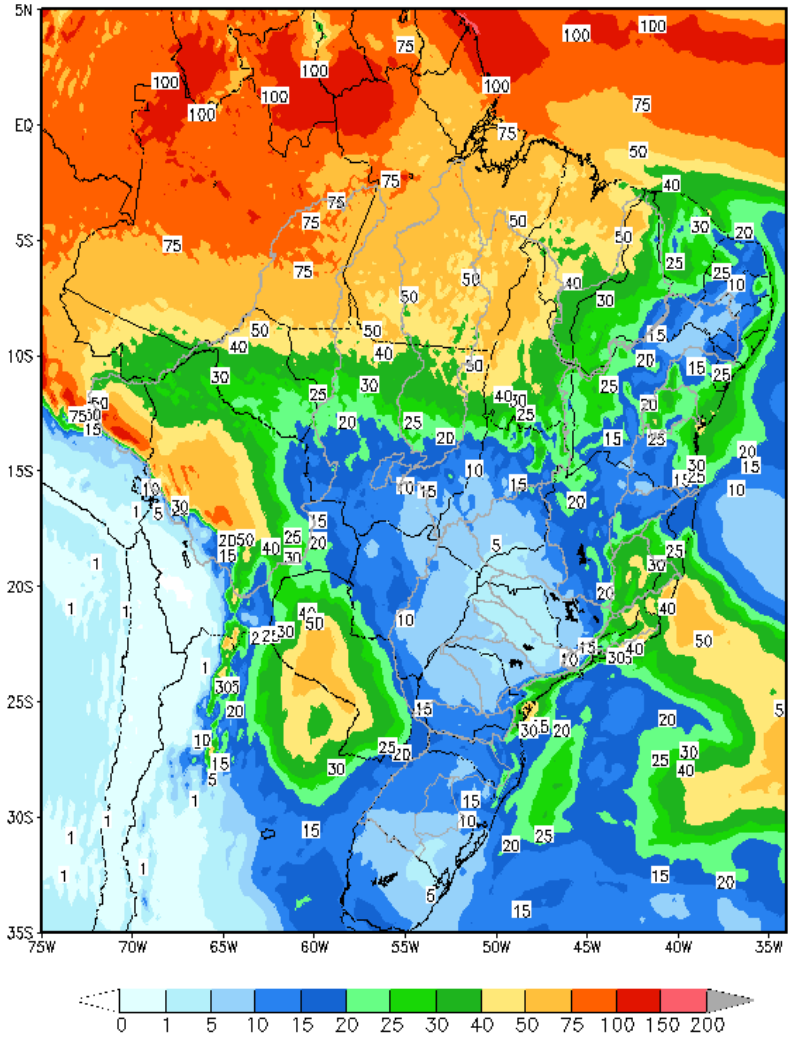

Em comparação com os valores estimados para a semana em curso, prevê-se para a próxima semana operativa recessão nas afluências de todos os subsistemas. A previsão mensal para abril indica a ocorrência de afluências abaixo da média histórica para todos os subsistemas.

Tabela 1 – Previsão de ENAs da Revisão 4 de Abril/2021

Revisão 4 do PMO de abril/2021 - ENAs previstas				
Subsistema	24/04 a 30/04/2021		Mês de abril	
	MWmed	%MLT	MWmed	%MLT
SE/CO	29.502	54	34.523	63
S	1.527	23	2.272	34
NE	3.283	28	4.071	35
N	18.544	69	22.016	82

O conteúdo desta publicação foi produzido pelo ONS com base em dados e informações de conhecimento público. É de responsabilidade exclusiva dos agentes e demais interessados a obtenção de outros dados e informações, a realização de análises, estudos e avaliações para fins de tomada de decisões, definição de estratégias de atuação, assunção de compromissos e obrigações e quaisquer outras finalidades, em qualquer tempo e sob qualquer condição. É proibida a reprodução ou utilização total ou parcial do presente sem a identificação da fonte.

4. PREVISÃO DE CARGA

A recuperação que vinha sendo observada no setor industrial brasileiro foi interrompida em março. Segundo a Sondagem da Industria da FGV – Fundação Getúlio Vargas, as medidas mais restritivas para contenção do Covid-19 em várias cidades e estados, lentidão do processo de vacinação, e o período de interrupção dos benefícios emergenciais estão afetando segmentos relevantes na indústria brasileira como o de alimentos, que também vem apresentando dificuldades com falta de matérias primas e elevação dos custos, levando a confiança da indústria ao menor nível desde maio de 2020. Esse fato associado a ocorrência de temperaturas mais amenas do que as observadas nos últimos três meses têm contribuído para o desempenho da carga durante o mês em análise.

As sinalizações meteorológicas indicam para todas as regiões manutenção das condições observadas na semana em curso, isto é, ocorrência de temperaturas amenas nas capitais dos subsistemas Sudeste/Centro-Oeste e Sul e para as capitais dos subsistemas Nordeste e Norte destaca-se os maiores totais de precipitação previstos para a próxima semana operativa.

As taxas de crescimento previstas para o mês de abril em relação ao mesmo mês do ano anterior, são de 10,1% no subsistema Sudeste/Centro-Oeste, 14,9% para o subsistema Sul, 12,2% no Nordeste e 20,3% no subsistema do Norte. Ressalta-se que as expressivas taxas de crescimento previstas estão influenciadas pelas reduções de carga observadas em abril/2020 devido às severas medidas de isolamento social implementadas no país para conter o avanço da pandemia.

Tabela 2 – Evolução da carga do PMO de Abril/2021

Subsistema	CARGA SEMANAL (MWmed)					CARGA MENSAL (MWmed)	
	1ª Sem	2ª Sem	3ª Sem	4ª Sem	5ª Sem	abr/21	Var. (%) abr/21 -> abr/20
SE/CO	40.816	39.078	39.597	38.039	38.468	38.930	10,1%
Sul	11.408	11.936	12.458	11.558	12.053	11.962	14,9%
Nordeste	10.929	11.013	11.121	11.175	11.251	11.126	12,2%
Norte	5.732	6.055	6.173	5.950	6.000	6.024	20,3%
SIN	**68.885**	**68.082**	**69.349**	**66.722**	**67.772**	**68.042**	**12,1%**

O conteúdo desta publicação foi produzido pelo ONS com base em dados e informações de conhecimento público. É de responsabilidade exclusiva dos agentes e demais interessados a obtenção de outros dados e informações, a realização de análises, estudos e avaliações para fins de tomada de decisões, definição de estratégias de atuação, assunção de compromissos e obrigações e quaisquer outras finalidades, em qualquer tempo e sob qualquer condição. É proibida a reprodução ou utilização total ou parcial do presente sem a identificação da fonte.

5. PRINCIPAIS RESULTADOS

5.1. CUSTO MARGINAL DE OPERAÇÃO (CMO)

A tabela a seguir apresenta o CMO, por subsistema e patamar de carga para próxima semana operativa.

Tabela 3 – CMO por patamar de carga

Patamares de Carga	CMO (R$/MWh)			
	SE/CO	S	NE	N
Pesada	181,45	181,45	144,91	144,91
Média	177,29	177,29	143,39	143,39
Leve	143,20	143,20	143,20	143,20
Média Semanal	162,29	162,29	143,75	143,75

Na figura a seguir é apresentada a evolução do CMO médio semanal ao longo deste PMO.

Figura 2 – Evolução semanal do CMO

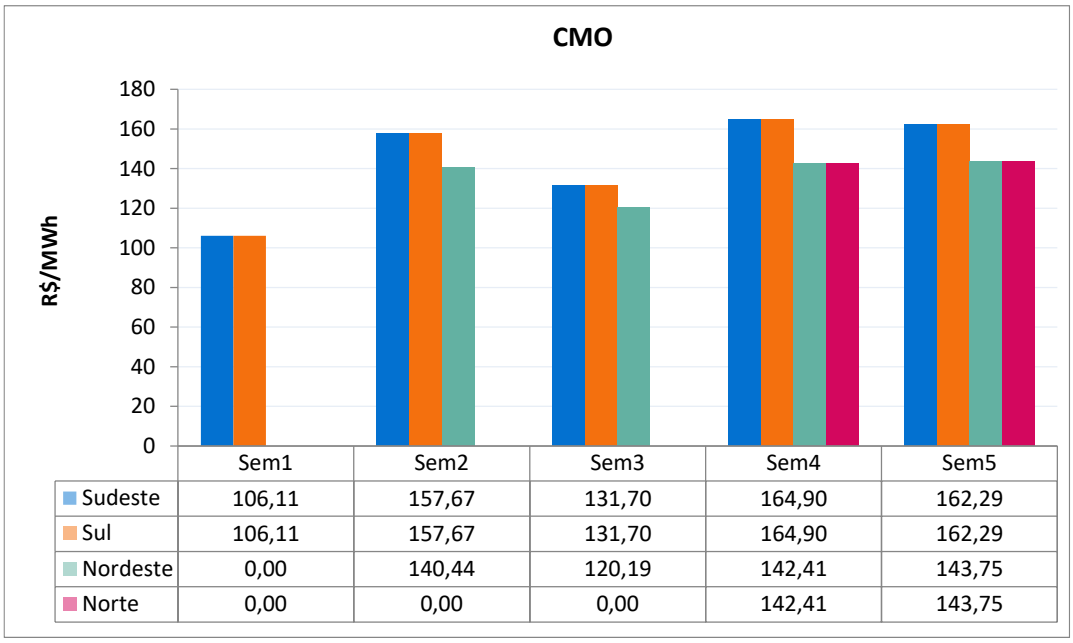

	Sem1	Sem2	Sem3	Sem4	Sem5
Sudeste	106,11	157,67	131,70	164,90	162,29
Sul	106,11	157,67	131,70	164,90	162,29
Nordeste	0,00	140,44	120,19	142,41	143,75
Norte	0,00	0,00	0,00	142,41	143,75

5.2. POLÍTICA DE OPERAÇÃO ENERGÉTICA

Para esta semana operativa, está prevista a seguinte política de intercâmbio de energia entre regiões:

Região SE/CO → Geração dimensionada para fechamento do balanço energético do SIN.

Região Sul → Geração hidráulica modulando em função dos recursos energéticos da região, com a exploração do intercâmbio de energia sempre que necessário, respeitando-se os limites elétricos vigentes.

Região NE → Redução da geração hidráulica e eólica e da exportação de energia, modulando em função dos recursos energéticos da região, respeitando-se os limites elétricos vigentes.

Região Norte → Continuidade da exploração das disponibilidades energéticas, respeitando-se os limites elétricos vigentes.

O conteúdo desta publicação foi produzido pelo ONS com base em dados e informações de conhecimento público. É de responsabilidade exclusiva dos agentes e demais interessados a obtenção de outros dados e informações, a realização de análises, estudos e avaliações para fins de tomada de decisões, definição de estratégias de atuação, assunção de compromissos e obrigações e quaisquer outras finalidades, em qualquer tempo e sob qualquer condição. É proibida a reprodução ou utilização total ou parcial do presente sem a identificação da fonte.

6. ANÁLISE DA VARIAÇÃO SEMANAL DO CMO

Esta análise visa identificar os principais parâmetros cujas atualizações impactaram os CMO deste PMO, em comparação com os valores obtidos na última revisão.

Foram realizados 8 estudos, onde o caso inicial foi construído com base nos dados oficiais da última revisão deste PMO. Neste primeiro estudo, denominado de "previsão perfeita", a partida dos reservatórios foi estimada conforme indicado para esta semana na última revisão.

O segundo estudo foi realizado com os dados do caso inicial sendo substituída a previsão de vazões.

A partir do conjunto de dados do segundo estudo foram elaborados os demais casos em que foram atualizados, sequencialmente, as seguintes informações: níveis de partida dos reservatórios, previsão de carga, disponibilidade das usinas térmicas e hidráulicas, restrições de limites de intercâmbio, restrições hidráulicas e, por fim, os demais dados que compõem toda informação referente a atual revisão.

A atualização da previsão de vazões apontou para uma elevação do CMO dos subsistemas Sudeste/Centro-Oeste, Sul. Entretanto, a redução da carga prevista para o SIN para a próxima semana resultou em redução do CMO. Dessa maneira, com a combinação destes efeitos, o CMO para esses subsistemas não sofreu alteração significativa em relação à semana anterior.

Para os subsistemas Nordeste e Norte as atualizações da previsão de vazões e dos níveis de partida dos reservatórios apontaram para uma elevação do CMO. Entretanto, a atualização das disponibilidades de usinas hidráulicas e térmicas levou à redução do CMO. Assim, o CMO para esses subsistemas também não sofreu alteração significativa em relação à semana anterior.

Os custos marginais de operação dos subsistemas Sudeste/Centro-Oeste e Sul estão acoplados e apresentados na figura a seguir.

Figura 3 – Análise da variação do CMO nos subsistemas SE/CO e Sul

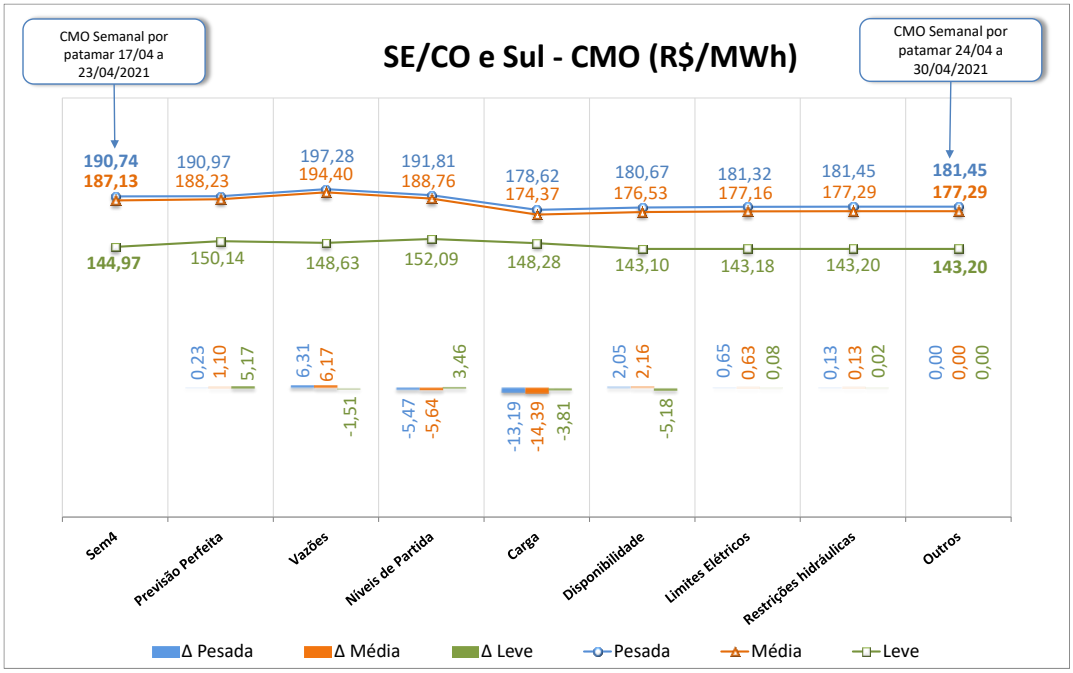

O conteúdo desta publicação foi produzido pelo ONS com base em dados e informações de conhecimento público. É de responsabilidade exclusiva dos agentes e demais interessados a obtenção de outros dados e informações, a realização de análises, estudos e avaliações para fins de tomada de decisões, definição de estratégias de atuação, assunção de compromissos e obrigações e quaisquer outras finalidades, em qualquer tempo e sob qualquer condição. É proibida a reprodução ou utilização total ou parcial do presente sem a identificação da fonte.

Os custos marginais de operação dos subsistemas Nordeste e Norte estão acoplados e a variação do CMO pode ser vista na figura abaixo.

Figura 4 – Análise da variação do CMO nos subsistemas Nordeste e Norte

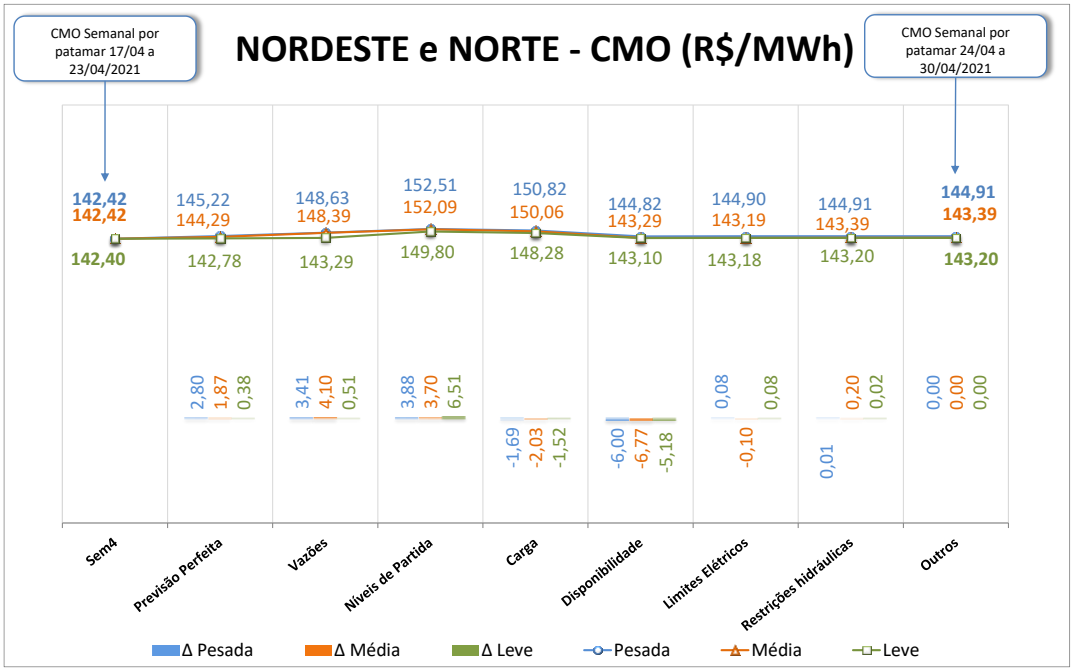

O conteúdo desta publicação foi produzido pelo ONS com base em dados e informações de conhecimento público. É de responsabilidade exclusiva dos agentes e demais interessados a obtenção de outros dados e informações, a realização de análises, estudos e avaliações para fins de tomada de decisões, definição de estratégias de atuação, assunção de compromissos e obrigações e quaisquer outras finalidades, em qualquer tempo e sob qualquer condição. É proibida a reprodução ou utilização total ou parcial do presente sem a identificação da fonte.

7. GERAÇÃO TÉRMICA

A Figura 5 apresenta, para cada subsistema, o despacho térmico por modalidade, para a próxima semana operativa.

Figura 5 – Geração térmica para a próxima semana operativa

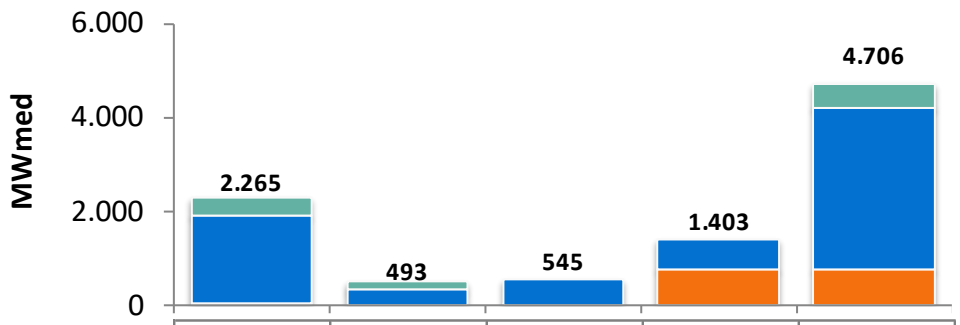

	SE/CO	SUL	NE	NORTE	SIN
INFLEXIBILIDADE	1888	333	537	658	3416
ORDEM DE MÉRITO	20	0	8	745	773
RESTRIÇÃO ELÉTRICA	357	160	0	0	517

Na tabela abaixo segue a Indicação de despacho antecipado por ordem de mérito de custo para a semana de 26/06/2021 a 02/07/2021.

Tabela 4 – UTEs com contrato de combustível GNL

UTE			Benefício (R$/MWh)		
Nome	Cod	CVU (R$/MWh)	Carga Pesada	Carga Média	Carga Leve
SANTA CRUZ	86	185,13	227,31 (1)	227,31 (1)	226,47 (1)
LUIZORMELO	15	280,64	227,31 (2)	227,31 (2)	226,47 (2)
PSERGIPE I	224	309,18	142,92 (2)	142,92 (2)	142,92 (2)

(1) Comandado o despacho antecipado por ordem de mérito de custo nesse patamar

(2) NÃO foi comandado o despacho antecipado por ordem de mérito de custo nesse patamar

Assim sendo, há previsão de despacho antecipado por ordem de mérito de custo apenas para a UTE Santa Cruz, para a semana de 26/06 a 02/07/2021.

Embora a UTE Luiz O. R. Melo não esteja despachada por ordem de mérito de custo, o ONS comanda seu despacho antecipado em sua totalidade, para a semana de 26/06 a 02/07/2021, por garantia energética.

O conteúdo desta publicação foi produzido pelo ONS com base em dados e informações de conhecimento público. É de responsabilidade exclusiva dos agentes e demais interessados a obtenção de outros dados e informações, a realização de análises, estudos e avaliações para fins de tomada de decisões, definição de estratégias de atuação, assunção de compromissos e obrigações e quaisquer outras finalidades, em qualquer tempo e sob qualquer condição. É proibida a reprodução ou utilização total ou parcial do presente sem a identificação da fonte.

8. IMPORTAÇÃO DE ENERGIA DA REPÚBLICA ORIENTAL DO URUGUAI

8.1. República Oriental do Uruguai

Para a próxima semana operativa, foram declaradas as seguintes ofertas de importação de energia da República Oriental do Uruguai para o Sistema Interligado Nacional - SIN através das conversoras de Rivera (70 MW) e Melo (500 MW).

- **Eletrobras**

Tabela 5 – Energia ofertada para importação

	Oferta de Energia para a Semana de 24/04 a 30/04 (MWmed)			
	Bloco 1	Bloco 2	Bloco 3	Total
Carga Pesada	-	150	135	285
Carga Média	-	150	135	285
Carga Leve	150	-	135	285
CVU (R$/MWh)	716,88	1.012,19	1.163,72	

- **Enel**

Conforme declaração do agente, esta importação poderá ser realizada exclusivamente pela conversora Melo.

Tabela 6 – Energia ofertada para importação

	Oferta de Energia para a Semana de 24/04 a 30/04 (MWmed)			
	Bloco 1	Bloco 2	Bloco 3	Total
Carga Pesada	-	150	135	285
Carga Média	-	150	135	285
Carga Leve	150	-	135	285
CVU (R$/MWh)	732,44	1.038,63	1.195,76	

O conteúdo desta publicação foi produzido pelo ONS com base em dados e informações de conhecimento público. É de responsabilidade exclusiva dos agentes e demais interessados a obtenção de outros dados e informações, a realização de análises, estudos e avaliações para fins de tomada de decisões, definição de estratégias de atuação, assunção de compromissos e obrigações e quaisquer outras finalidades, em qualquer tempo e sob qualquer condição. É proibida a reprodução ou utilização total ou parcial do presente sem a identificação da fonte.

8.2. República da Argentina

- **Enel**

Para a próxima semana operativa, foi declarada a seguinte oferta de importação de energia da República da Argentina para o SIN através das conversoras de Garabi 1 (1.100 MW) e Garabi 2 (1.100 MW).

Tabela 7 – Energia ofertada para importação

	Oferta de Energia para a Semana de 24/04 a 30/04 (MWmed)	
	Bloco 1	Total
Carga Pesada	300	300
Carga Média	300	300
Carga Leve	300	300
CVU (R$/MWh)	1.725,22	

Nota: Detalhes sobre a importação de energia vide Portaria Nº 339, de 15 de agosto de 2018 disponível em: http://pesquisa.in.gov.br/imprensa/jsp/visualiza/index.jsp?data=17/08/2018&jornal=515&pagina=60&totalArquivos=136

9. ESTIMATIVA DE ENCARGOS OPERATIVOS

A tabela a seguir apresenta a expectativa do custo de despacho térmico por restrição elétrica para esta semana operativa.

Tabela 8 – Expectativa de custo de despacho térmico por Restrição Elétrica

UTE Potência Instalada (MW)	CVU (R$/MWh)	Geração (MWmed)			ESS ELÉTRICO
		Carga Pesada	Carga Média	Carga Leve	
NORTEFLU 3 (200)	R$ 187,93	50,0	50,0	21,2	**R$ 112.278,09**
LUIZORMELO (204)	R$ 280,64	196,0	196,0	196,0	**R$ 3.896.872,05**
JUIZ DE FO (87)	R$ 283,74	0,0	0,0	10,0	**R$ 112.432,00**
VIANA (175)	R$ 968,04	165,8	165,8	70,5	**R$ 16.154.970,11**
TOTAL SE/CO					R$ 20.276.552,25

O conteúdo desta publicação foi produzido pelo ONS com base em dados e informações de conhecimento público. É de responsabilidade exclusiva dos agentes e demais interessados a obtenção de outros dados e informações, a realização de análises, estudos e avaliações para fins de tomada de decisões, definição de estratégias de atuação, assunção de compromissos e obrigações e quaisquer outras finalidades, em qualquer tempo e sob qualquer condição. É proibida a reprodução ou utilização total ou parcial do presente sem a identificação da fonte.

10. ARMAZENAMENTOS OPERATIVOS

Para uma melhor avaliação de diversos cenários hidrometeorológicos, notadamente, aqueles de curto prazo e suas influências nas previsões de vazões nos subsistemas, os resultados desta revisão do PMO contemplam cenários de afluências visando melhor representar a ocorrência de precipitação e, consequentemente, seus efeitos sobre as afluências e armazenamentos.

Além dos resultados associados ao valor esperado das previsões de afluências, as simulações operativas também foram realizadas com os limites superior e inferior das previsões de afluências. Apresentamos a seguir os resultados obtidos com a aplicação dos diferentes cenários de afluência.

Tabela 9 – Previsão de ENA dos cenários de sensibilidade

Subsistema	ENERGIAS NATURAIS AFLUENTES					
	Previsão Mensal					
	LI		VE		LS	
	(MWmed)	%MLT	(MWmed)	%MLT	(MWmed)	%MLT
SE/CO	33.635	**61**	34.523	**63**	35.407	**65**
Sul	2.128	**32**	2.272	**34**	2.426	**37**
Nordeste	3.931	**34**	4.071	**35**	4.211	**36**
Norte	21.324	**79**	22.016	**82**	22.708	**84**

Tabela 10 – Previsão de %EARmáx para o final do mês

Subsistema	% EARmáx 23/04	% EARmáx - 30/04		
	NÍVEL INICIAL	NÍVEL PMO		
	VE	LI	VE	LS
SE/CO	35,0	34,4	34,6	34,9
Sul	57,7	56,2	56,9	57,6
Nordeste	67,6	65,4	66,4	67,3
Norte	81,2	80,5	82,6	82,8

O conteúdo desta publicação foi produzido pelo ONS com base em dados e informações de conhecimento público. É de responsabilidade exclusiva dos agentes e demais interessados a obtenção de outros dados e informações, a realização de análises, estudos e avaliações para fins de tomada de decisões, definição de estratégias de atuação, assunção de compromissos e obrigações e quaisquer outras finalidades, em qualquer tempo e sob qualquer condição. É proibida a reprodução ou utilização total ou parcial do presente sem a identificação da fonte.

11. RESERVATÓRIOS EQUIVALENTES DE ENERGIA

A seguir são apresentadas as previsões de Energia Natural Afluente para a próxima semana operativa e para o mês de abril, bem como as previsões de Energia Armazenada nos Reservatórios Equivalentes de Energia – REE, desta revisão do PMO.

Tabela 11 – Previsão de ENA por REE

Valor Esperado das Energias Naturais Afluentes				
REE	Previsão Semanal		Previsão Mensal	
	24/04/2021 a 30/04/2021		abr/21	
	(MWmed)	%MLT	(MWmed)	%MLT
Sudeste	3.539	49	4.093	56
Madeira	8.475	73	9.651	83
Teles Pires	2.591	81	3.050	96
Itaipu	2.135	60	2.625	73
Paraná	9.820	37	11.776	44
Paranapanema	909	38	1.040	44
Sul	646	20	912	28
Iguaçu	881	26	1.360	41
Nordeste	3.283	28	4.071	35
Norte	8.656	59	10.101	69
Belo Monte	8.042	74	10.327	95
Manaus	2.123	135	2.085	133

Tabela 12 – Previsão de %EARmáx por REE

% Energia Armazenável Máxima		
REE	Previsão Semanal	Previsão Mensal
	30-abr	30-abr
	(%EARmáx)	(%EARmáx)
Sudeste	42,1	42,1
Madeira	97,8	97,8
Teles Pires	86,4	86,4
Itaipu	5,4	5,4
Paraná	31,2	31,2
Paranapanema	40,4	40,4
Sul	42,1	42,1
Iguaçu	70,3	70,3
Nordeste	66,4	66,4
Norte	84,1	84,1
Belo Monte	100,0	100,0
Manaus	56,0	56,0

O conteúdo desta publicação foi produzido pelo ONS com base em dados e informações de conhecimento público. É de responsabilidade exclusiva dos agentes e demais interessados a obtenção de outros dados e informações, a realização de análises, estudos e avaliações para fins de tomada de decisões, definição de estratégias de atuação, assunção de compromissos e obrigações e quaisquer outras finalidades, em qualquer tempo e sob qualquer condição. É proibida a reprodução ou utilização total ou parcial do presente sem a identificação da fonte.

12. DESPACHO TÉRMICO POR MODALIDADE, PATAMAR DE CARGA E USINA

Nas tabelas abaixo, a diferenciação entre geração por inflexibilidade e por ordem de mérito tem caráter informativo, com o objetivo de detalhar a informação de inflexibilidade enviada pelos respectivos agentes para esta revisão do PMO. Ressalta-se que nas etapas de Programação Diária e Tempo Real, o montante despachado nas usinas termelétricas indicadas por ordem de mérito é plenamente intitulado como ordem de mérito.

REGIÃO SUDESTE/CENTRO-OESTE

Térmicas Potência (MW)	Combustível	CVU (R$/MWh)	Inflexibilidade			Ordem de Mérito			Total Mérito e INFL.			Razão Elétrica			Total UTE		
			P	M	L	P	M	L	P	M	L	P	M	L	P	M	L
ATLAN_CSA (255)	Resíduos	0,00															
ANGRA 2 (1350)	Nuclear	20,12	1220,0	1220,0	1220,0	0,0	0,0	0,0	1220,0	1220,0	1220,0				1220,0	1220,0	1220,0
ANGRA 1 (640)	Nuclear	31,17				0,0	0,0	0,0	0,0	0,0	0,0				0,0	0,0	0,0
NORTEFLU 1 (400)	Gás	85,23	400,0	400,0	400,0	0,0	0,0	0,0	400,0	400,0	400,0				400,0	400,0	400,0
NORTEFLU 2 (100)	Gás	98,99	100,0	100,0	100,0	0,0	0,0	0,0	100,0	100,0	100,0				100,0	100,0	100,0
UTE STA VI (41)	Biomassa	121,49				20,0	20,0	20,0	20,0	20,0	20,0				20,0	20,0	20,0
BAIXADA FL (530)	Gás	182,20															
SANTA CRUZ (500)	GNL	185,13															
NORTEFLU 3 (200)	Gás	187,93										50,0	50,0	21,2	50,0	50,0	21,2
ATLANTICO (235)	Resíduos	195,80	168,0	168,0	168,0				168,0	168,0	168,0				168,0	168,0	168,0
T.LAGOAS (350)	Gás	261,44															
LUIZORMELO (204)	GNL	280,64										196,0	196,0	196,0	196,0	196,0	196,0
JUIZ DE FO (87)	Gás	283,74												10,0	0,0	0,0	10,0
ST.CRUZ 34 (436)	Óleo	310,41															
TERMORIO (1036)	Gás	327,82															
CUBATAO (216)	Gás	338,77															
IBIRITE (226)	Gás	393,64															
SEROPEDICA (386)	Gás	408,99															
PIRAT.12 O (200)	Gás	470,34															
CUIABA CC (529)	Gás	543,82															
NORTEFLU 4 (127)	Gás	546,47															
NPIRATINGA (572)	Gás	548,04															
T.MACAE (929)	Gás	736,13															
PALMEIR_GO (176)	Diesel	761,51															
TNORTE 2 (340)	Óleo	910,86															
VIANA (175)	Óleo	968,04										165,8	165,8	70,5	165,8	165,8	70,5
CAMPOS (25)	Gás	978,10															
DAIA (44)	Diesel	1017,64															
GOIANIA 2 (140)	Diesel	1064,13															
XAVANTES (54)	Diesel	1462,46															
TOTAL SE/CO (10503)			1888,0	1888,0	1888,0	20,0	20,0	20,0	1908,0	1908,0	1908,0	411,8	411,8	297,7	2319,8	2319,8	2205,7

REGIÃO SUL

Térmicas Potência (MW)	Combustível	CVU (R$/MWh)	Inflexibilidade			Ordem de Mérito			Total Mérito e INFL.			Razão Elétrica			Total UTE		
			P	M	L	P	M	L	P	M	L	P	M	L	P	M	L
PAMPA SUL (345)	Carvão	69,75				0,0	0,0	0,0	0,0	0,0	0,0				0,0	0,0	0,0
SAO SEPE (8)	Biomassa	87,75	6,0	6,0	6,0	0,0	0,0	0,0	6,0	6,0	6,0				6,0	6,0	6,0
CANDIOTA_3 (350)	Carvão	87,78	325,0	325,0	325,0	0,0	0,0	0,0	325,0	325,0	325,0				325,0	325,0	325,0
J.LACER. C (363)	Carvão	206,84															
J.LACER. B (262)	Carvão	244,14										160,0	160,0	160,0	160,0	160,0	160,0
J.LAC. A2 (132)	Carvão	245,21															
J.LAC. A1 (100)	Carvão	270,48															
MADEIRA (4)	Biomassa	314,98	2,0	2,0	2,0				2,0	2,0	2,0				2,0	2,0	2,0
FIGUEIRA (20)	Carvão	475,68															
URUGUAIANA (640)	Gás	606,28															
CANOAS (249)	Diesel	698,14															
ARAUCARIA (484)	Gás	699,11															
TOTAL SUL (2957)			333,0	333,0	333,0	0,0	0,0	0,0	333,0	333,0	333,0	160,0	160,0	160,0	493,0	493,0	493,0

O conteúdo desta publicação foi produzido pelo ONS com base em dados e informações de conhecimento público. É de responsabilidade exclusiva dos agentes e demais interessados a obtenção de outros dados e informações, a realização de análises, estudos e avaliações para fins de tomada de decisões, definição de estratégias de atuação, assunção de compromissos e obrigações e quaisquer outras finalidades, em qualquer tempo e sob qualquer condição. É proibida a reprodução ou utilização total ou parcial do presente sem a identificação da fonte.

REGIÃO NORDESTE

Térmicas Potência (MW)	Combustível	CVU (R$/MWh)	Inflexibilidade			Ordem de Mérito			Total Mérito e INFL.			Razão Elétrica			Total UTE		
			P	M	L	P	M	L	P	M	L	P	M	L	P	M	L
ERB CANDEI (17)	Biomassa	87,81	4,5	4,5	4,5	8,5	8,5	8,5	13,0	13,0	13,0				13,0	13,0	13,0
TERMOPE (533)	Gás	165,28	532,7	532,7	532,7				532,7	532,7	532,7				532,7	532,7	532,7
PROSPERIDA (28)	Gás	165,61															
FORTALEZA (327)	Gás	223,72															
P.PECEM1 (720)	Carvão	227,74															
P.PECEM2 (365)	Carvão	235,66															
PSERGIPE I (1516)	GNL	309,18															
TERMOCEARA (223)	Gás	428,47															
VALE ACU (368)	Gás	435,93															
T.BAHIA (186)	Gás	442,21															
SYKUE I (30)	Biomassa	510,12															
BAHIA_1 (31)	Óleo	816,03															
PERNAMBU_3 (201)	Óleo	835,59															
ALTOS (13)	Diesel	881,41															
ARACATI (11)	Diesel	881,41															
BATURITE (11)	Diesel	881,41															
C.MAIOR (13)	Diesel	881,41															
CAUCAIA (15)	Diesel	881,41															
CRATO (13)	Diesel	881,41															
IGUATU (15)	Diesel	881,41															
JUAZEIRO N (15)	Diesel	881,41															
MARAMBAIA (13)	Diesel	881,41															
NAZARIA (13)	Diesel	881,41															
PECEM (15)	Diesel	881,41															
MARACANAU (168)	Óleo	942,18															
TERMOCABO (50)	Óleo	956,14															
TERMONE (171)	Óleo	959,30															
TERMOPB (171)	Óleo	959,30															
CAMPINA_GR (169)	Óleo	968,06															
SUAPE II (381)	Óleo	991,19															
POTIGUAR_3 (66)	Diesel	1001,38															
POTIGUAR (53)	Diesel	1001,39															
AREMBEPE (150)	Óleo	1019,77															
MURICY (147)	Óleo	1019,77															
GLOBAL I (149)	Óleo	1096,65															
GLOBAL II (149)	Óleo	1096,65															
PETROLINA (136)	Óleo	1118,83															
PAU FERRO (94)	Diesel	1133,69															
TERMOMANAU (143)	Diesel	1133,69															
TOTAL NE (6889)			537,2	537,2	537,2	8,5	8,5	8,5	545,7	545,7	545,7	0,0	0,0	0,0	545,7	545,7	545,7

REGIÃO NORTE

Térmicas Potência (MW)	Combustível	CVU (R$/MWh)	Inflexibilidade			Ordem de Mérito			Total Mérito e INFL.			Razão Elétrica			Total UTE		
			P	M	L	P	M	L	P	M	L	P	M	L	P	M	L
C. ROCHA (85)	Gás	0,00	65,0	65,0	65,0				65,0	65,0	65,0				65,0	65,0	65,0
JARAQUI (75)	Gás	0,00	63,0	63,0	63,0				63,0	63,0	63,0				63,0	63,0	63,0
MANAUARA (67)	Gás	0,00	64,5	64,5	64,5				64,5	64,5	64,5				64,5	64,5	64,5
PONTA NEGR (66)	Gás	0,00	64,0	64,0	64,0				64,0	64,0	64,0				64,0	64,0	64,0
TAMBAQUI (93)	Gás	0,00	63,0	63,0	63,0				63,0	63,0	63,0				63,0	63,0	63,0
MARANHAO3 (519)	Gás	85,72				490,0	515,8	513,0	490,0	515,8	513,0				490,0	515,8	513,0
APARECIDA (166)	Gás	90,75	75,0	75,0	75,0	1,0	1,0	1,0	76,0	76,0	76,0				76,0	76,0	76,0
UTE MAUA 3 (591)	Gás	90,75	264,0	264,0	264,0	326,8	260,5	169,4	590,8	524,5	433,4				590,8	524,5	433,4
PARNAIB_IV (56)	Gás	151,69															
MARAN_VL_7 (336)	Gás	171,23															
MARAN_VL22 (1)	Gás	171,23															
MARANIVL_7 (336)	Gás	171,23															
MARANIVL22 (1)	Gás	171,23															
P. ITAQUI (360)	Carvão	229,67															
N.VEN2_L22 (27)	Gás	232,01															
N.VEN2_L7 (151)	Gás	232,27															
GERAMAR1 (166)	Óleo	968,02															
GERAMAR2 (166)	Óleo	968,02															
TOTAL NORTE (3264)			658,5	658,5	658,5	817,8	777,3	683,4	1476,3	1435,8	1341,9	0,0	0,0	0,0	1476,3	1435,8	1341,9

O conteúdo desta publicação foi produzido pelo ONS com base em dados e informações de conhecimento público. É de responsabilidade exclusiva dos agentes e demais interessados a obtenção de outros dados e informações, a realização de análises, estudos e avaliações para fins de tomada de decisões, definição de estratégias de atuação, assunção de compromissos e obrigações e quaisquer outras finalidades, em qualquer tempo e sob qualquer condição. É proibida a reprodução ou utilização total ou parcial do presente sem a identificação da fonte.