1. APRESENTAÇÃO

Na semana de 01/05 a 07/05 houve chuva fraca em pontos isolados das bacias dos rios Tocantins, Xingu, Madeira e do trecho baixo do São Francisco. Na região Sul, ocorreu chuva fraca à moderada na bacia do rio Jacuí e em pontos isolados do Uruguai e do Iguaçu.

Na semana de 08/05 a 14/04 a condição de precipitação permanece no trecho médio e baixo das bacias dos rios Tocantins e Xingu, na bacia do rio Madeira e no baixo São Francisco. Na região Sul, deve ocorrer chuva fraca nas bacias dos rios Jacuí, Uruguai, Iguaçu e em pontos isolados da incremental a UHE Itaipu.

Para a semana operativa de 08/05 a 14/05/2021, houve oferta de energia da República Oriental do Uruguai. De acordo com o Art. 2º da Portaria MME nº 339, de 15 de agosto de 2018, as ofertas para importação de energia não foram consideradas na elaboração do PMO. Para a referida semana, não houve oferta de energia da República da Argentina.

Os valores médios semanais do Custo Marginal de Operação – CMO dos subsistemas do SIN sofreram as seguintes alterações em relação à semana anterior:

- SE/CO: de R$ 173,48/MWh para R$ 172,56/MWh
- Sul: de R$ 173,48/MWh para R$ 172,56/MWh
- Nordeste: de R$ 0,00/MWh para R$ 85,72/MWh
- Norte: de R$ 0,00/MWh para R$ 85,72/MWh

Desde o dia 01/01/2020, o despacho por ordem de mérito é indicado diariamente pelos resultados do modelo DESSEM. Assim, o despacho por ordem de mérito semanal, conforme publicado nesse documento, tem caráter apenas informativo. Da mesma forma, desde o dia 01/01/2021, a formação de preço deixou o formato semanal/patamar de carga e passou a ser horário, de acordo também com os resultados do modelo DESSEM.

2. NOTÍCIAS

Nos dias 27 e 28 de maio será realizada a reunião de elaboração do PMO Junho de 2021, com transmissão ao vivo através do site do ONS.

Como medida adicional de prevenção ao Coronavírus, o ONS informa que está suspensa, temporariamente, a participação presencial nas reuniões.

3. ANÁLISE DAS CONDIÇÕES HIDROMETEOROLÓGICAS

3.1. PREVISÃO PARA A PRÓXIMA SEMANA

Na próxima semana operativa, a condição de precipitação permanece no trecho médio e baixo das bacias dos rios Tocantins e Xingu, na bacia do rio Madeira e no baixo São Francisco. Na região Sul, o

O conteúdo desta publicação foi produzido pelo ONS com base em dados e informações de conhecimento público. É de responsabilidade exclusiva dos agentes e demais interessados a obtenção de outros dados e informações, a realização de análises, estudos e avaliações para fins de tomada de decisões, definição de estratégias de atuação, assunção de compromissos e obrigações e quaisquer outras finalidades, em qualquer tempo e sob qualquer condição. É proibida a reprodução ou utilização total ou parcial do presente sem a identificação da fonte.

avanço de uma nova frente fria ocasiona chuva fraca nas bacias dos rios Jacuí, Uruguai, Iguaçu e em pontos isolados da incremental a UHE Itaipu (**Figura 1**).

Figura 1- Precipitação acumulada prevista pelo modelo ECMWF (ECMWF) para o período de 08/05 a 14/05/2021.

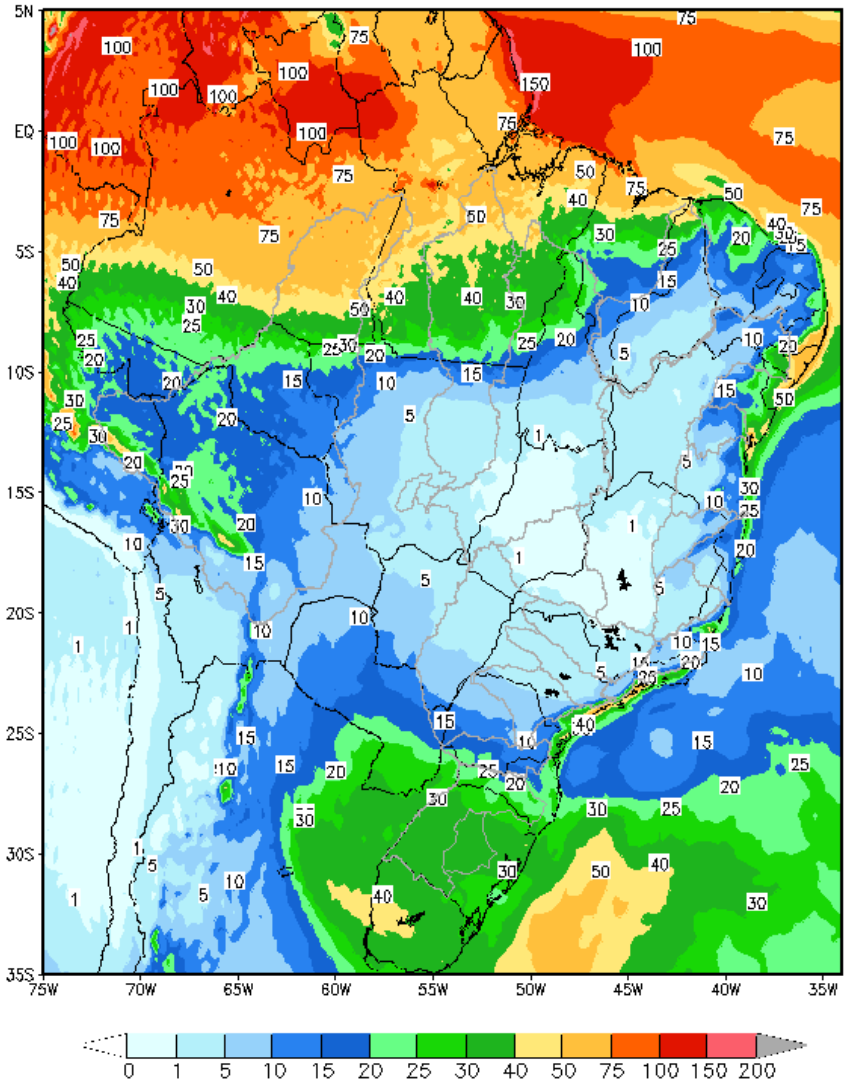

Em comparação com os valores estimados para a semana em curso, prevê-se para a próxima semana operativa recessão nas afluências dos subsistemas Sudeste/Centro-Oeste e Norte, leve aumento nas afluências do subsistema Sul e estabilidade nas afluências do subsistema Nordeste. A previsão mensal para maio indica a ocorrência de afluências abaixo da média histórica para todos os subsistemas.

Tabela 1 – Previsão de ENAs da Revisão 1 de Maio/2021

Revisão 1 do PMO de Maio/2021 - ENAs previstas				
Subsistema	08/05 a 14/05/2021		Mês de maio	
	MWmed	%MLT	MWmed	%MLT
SE/CO	25.775	65	25.745	64
S	1.510	17	2.154	25
NE	2.932	42	2.796	40
N	18.558	91	16.789	82

O conteúdo desta publicação foi produzido pelo ONS com base em dados e informações de conhecimento público. É de responsabilidade exclusiva dos agentes e demais interessados a obtenção de outros dados e informações, a realização de análises, estudos e avaliações para fins de tomada de decisões, definição de estratégias de atuação, assunção de compromissos e obrigações e quaisquer outras finalidades, em qualquer tempo e sob qualquer condição. É proibida a reprodução ou utilização total ou parcial do presente sem a identificação da fonte.

4. PREVISÃO DE CARGA

Apesar do resultado dos indicadores observados nos primeiros meses de 2021 já demostrarem um arrefecimento do ritmo de recuperação observado ao final de 2020, o uso intensivo de aparelhos de ventilação e refrigeração, em virtude da ocorrência das elevadas temperaturas observadas, mantiveram a carga de energia em patamar elevado. A partir de abril com a ocorrência de temperaturas mais amenas observou-se uma redução na carga de 6,4% em relação a março/21. As previsões de carga consolidadas para o mês de maio/2021 levaram em consideração a menor desempenho da indústria, corroborada pelo resultado da sondagem Industrial da FGV de abril/21, cujos dados indicam o pior resultado desde agosto de 2020, tanto para o indicador de confiança da Indústria quanto para a utilização da Capacidade Instalada.

As previsões meteorológicas indicam para a próxima semana operativa, temperaturas estáveis em relação a semana em curso nas capitais das regiões Sul, Nordeste e Norte. Dessa forma, destaca-se a ocorrência de temperaturas amenas nas capitais dos subsistemas Sudeste/Centro-Oeste e Sul e para as capitais dos subsistemas Nordeste e Norte são esperados para a próxima semana a manutenção dos totais de precipitação observado na semana em curso.

As taxas de crescimento previstas para o mês de maio em relação ao mesmo mês do ano anterior, são de 12,1% para os subsistemas Sudeste/Centro-Oeste e Sul, 12,7% no Nordeste e 13,8% no subsistema do Norte. É importante observar que as expressivas taxas de crescimento previstas estão influenciadas pelas reduções de carga observadas em maio/2020 devido as severas medidas de isolamento social implementadas no país para conter o avanço da pandemia.

Tabela 2 – Evolução da carga do PMO de Maio/2021

Subsistema	CARGA SEMANAL (MWmed)					CARGA MENSAL (MWmed)	
	1ª Sem	2ª Sem	3ª Sem	4ª Sem	5ª Sem	mai/21	Var. (%) mai/21 -> mai/20
SE/CO	38.542	38.784	38.638	38.304	37.138	38.429	11,1%
Sul	11.819	11.697	11.690	11.592	10.838	11.616	12,4%
Nordeste	10.707	10.906	11.186	11.054	10.651	10.933	11,2%
Norte	5.768	5.869	5.888	5.871	5.765	5.841	12,1%
SIN	66.836	67.256	67.402	66.821	64.392	66.819	11,4%

O conteúdo desta publicação foi produzido pelo ONS com base em dados e informações de conhecimento público. É de responsabilidade exclusiva dos agentes e demais interessados a obtenção de outros dados e informações, a realização de análises, estudos e avaliações para fins de tomada de decisões, definição de estratégias de atuação, assunção de compromissos e obrigações e quaisquer outras finalidades, em qualquer tempo e sob qualquer condição. É proibida a reprodução ou utilização total ou parcial do presente sem a identificação da fonte.

5. PRINCIPAIS RESULTADOS

5.1. CUSTO MARGINAL DE OPERAÇÃO (CMO)

A tabela a seguir apresenta o CMO, por subsistema e patamar de carga para próxima semana operativa.

Tabela 3 – CMO por patamar de carga

Patamares de Carga	CMO (R$/MWh)			
	SE/CO	S	NE	N
Pesada	244,10	244,10	85,72	85,72
Média	239,85	239,85	85,72	85,72
Leve	85,72	85,72	85,72	85,72
Média Semanal	172,56	172,56	85,72	85,72

Na figura a seguir é apresentada a evolução do CMO médio semanal ao longo deste PMO.

Figura 2 – Evolução semanal do CMO

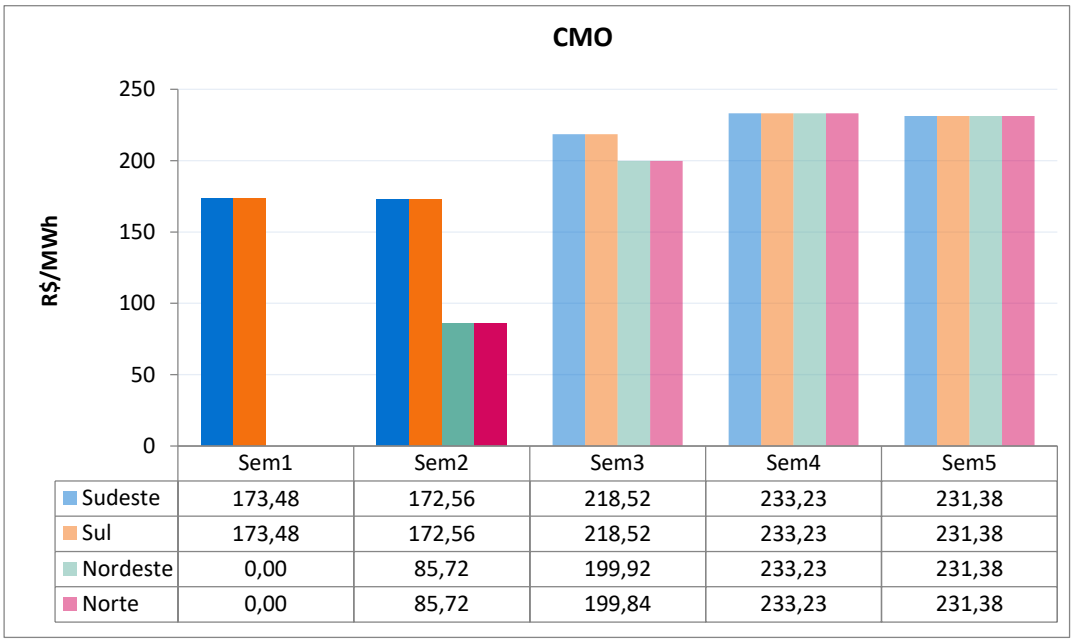

5.2. POLÍTICA DE OPERAÇÃO ENERGÉTICA

Para esta semana operativa, está prevista a seguinte política de intercâmbio de energia entre regiões:

Região SE/CO → Geração minimizada de acordo com os condicionantes hidráulicos.

Região Sul → Geração dimensionada para fechamento do balanço energético do SIN.

Região NE → Aumento da geração eólica e possível exportação de energia, modulando em função de seus recursos energéticos, respeitando-se os limites elétricos vigentes.

Região Norte → Continuidade da exploração das disponibilidades energéticas, respeitando-se os limites elétricos vigentes.

O conteúdo desta publicação foi produzido pelo ONS com base em dados e informações de conhecimento público. É de responsabilidade exclusiva dos agentes e demais interessados a obtenção de outros dados e informações, a realização de análises, estudos e avaliações para fins de tomada de decisões, definição de estratégias de atuação, assunção de compromissos e obrigações e quaisquer outras finalidades, em qualquer tempo e sob qualquer condição. É proibida a reprodução ou utilização total ou parcial do presente sem a identificação da fonte.

6. ANÁLISE DA VARIAÇÃO SEMANAL DO CMO

Esta análise visa identificar os principais parâmetros cujas atualizações impactaram os CMO deste PMO, em comparação com os valores obtidos na última revisão.

Foram realizados 8 estudos, onde o caso inicial foi construído com base nos dados oficiais da última revisão deste PMO. Neste primeiro estudo, denominado de "previsão perfeita", a partida dos reservatórios foi estimada conforme indicado para esta semana na última revisão.

O segundo estudo foi realizado com os dados do caso inicial sendo substituída a previsão de vazões.

A partir do conjunto de dados do segundo estudo foram elaborados os demais casos em que foram atualizados, sequencialmente, as seguintes informações: níveis de partida dos reservatórios, previsão de carga, disponibilidade das usinas térmicas e hidráulicas, restrições de limites de intercâmbio, restrições hidráulicas e, por fim, os demais dados que compõem toda informação referente a atual revisão.

A atualização da previsão de vazões apontou para uma pequena redução dos CMO dos subsistemas Sudeste/Centro-Oeste e Sul, nos patamares de carga pesada e média, enquanto que houve uma elevação no patamar de carga leve. A atualização dos níveis dos reservatórios para o SIN e a revisão da previsão de carga também contribuíram para redução dos CMO. Dessa maneira, com a combinação destes efeitos, o CMO para esses subsistemas não sofreu alteração significativa em relação à semana anterior.

Para os subsistemas Nordeste e Norte já era prevista a elevação do CMO para essa semana, como pode ser observado no resultado do estudo de "previsão perfeita". Entretanto, combinando os efeitos da atualização da previsão de vazões e dos níveis de partida, esta elevação não foi tão acentuada.

Os custos marginais de operação dos subsistemas Sudeste/Centro-Oeste e Sul estão acoplados e apresentados na figura a seguir.

Figura 3 – Análise da variação do CMO nos subsistemas SE/CO e Sul

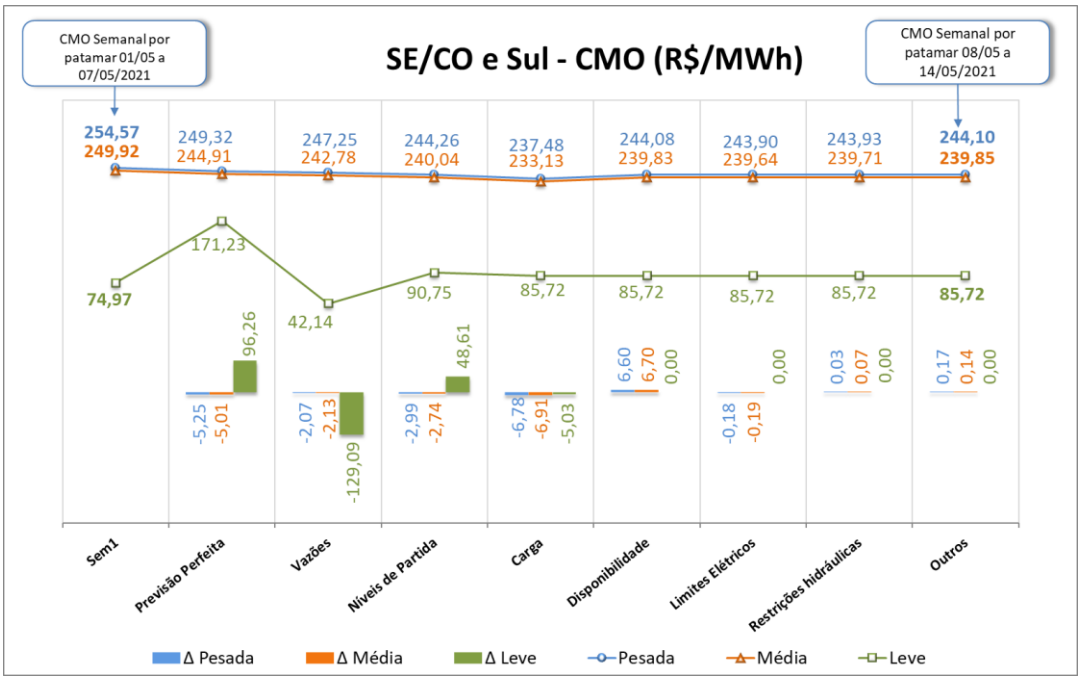

O conteúdo desta publicação foi produzido pelo ONS com base em dados e informações de conhecimento público. É de responsabilidade exclusiva dos agentes e demais interessados a obtenção de outros dados e informações, a realização de análises, estudos e avaliações para fins de tomada de decisões, definição de estratégias de atuação, assunção de compromissos e obrigações e quaisquer outras finalidades, em qualquer tempo e sob qualquer condição. É proibida a reprodução ou utilização total ou parcial do presente sem a identificação da fonte.

Os custos marginais de operação dos subsistemas Nordeste e Norte estão acoplados e a variação do CMO pode ser vista na figura abaixo.

Figura 4 – Análise da variação do CMO nos subsistemas Nordeste e Norte

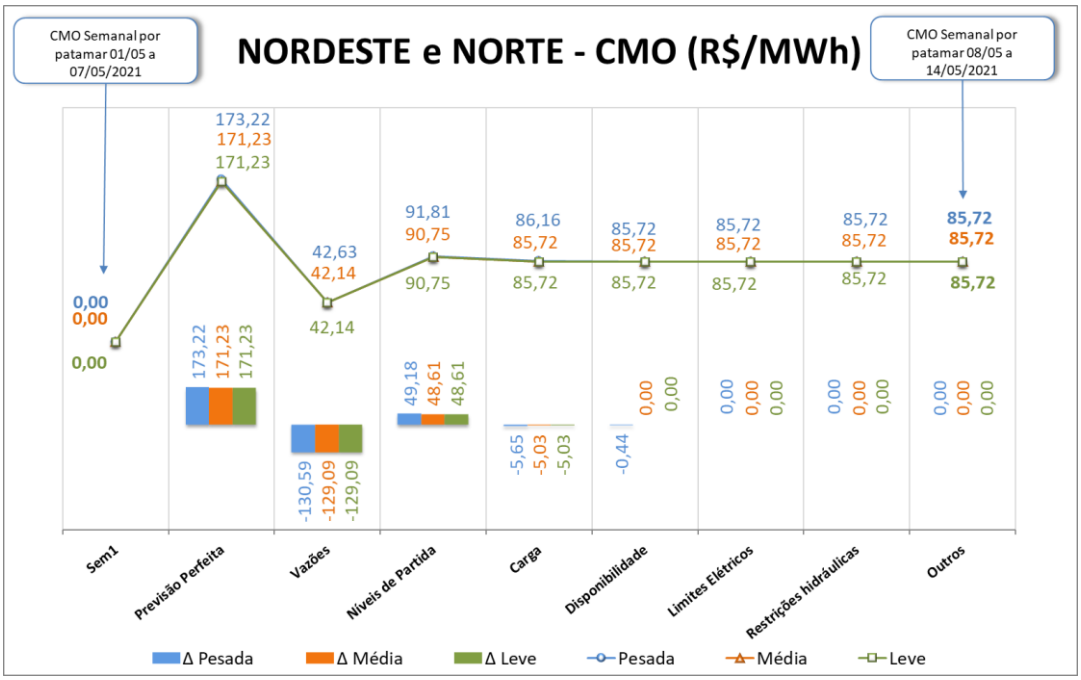

Destaca-se, adicionalmente, que os CMO do patamar de carga leve dos quatro subsistemas estão acoplados.

O conteúdo desta publicação foi produzido pelo ONS com base em dados e informações de conhecimento público. É de responsabilidade exclusiva dos agentes e demais interessados a obtenção de outros dados e informações, a realização de análises, estudos e avaliações para fins de tomada de decisões, definição de estratégias de atuação, assunção de compromissos e obrigações e quaisquer outras finalidades, em qualquer tempo e sob qualquer condição. É proibida a reprodução ou utilização total ou parcial do presente sem a identificação da fonte.

7. GERAÇÃO TÉRMICA

A Figura 5 apresenta, para cada subsistema, o despacho térmico por modalidade, para a próxima semana operativa.

Figura 5 – Geração térmica para a próxima semana operativa

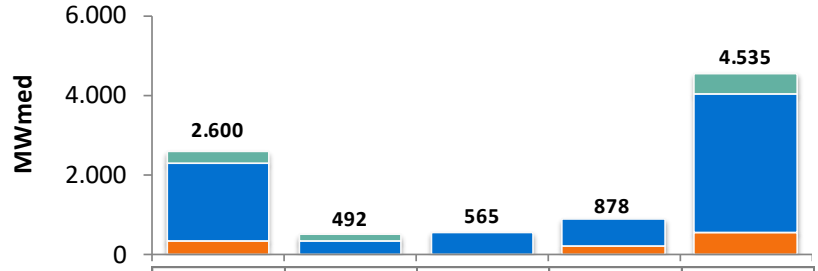

	SE/CO	SUL	NE	NORTE	SIN
INFLEXIBILIDADE	1938	332	565	658	3493
ORDEM DE MÉRITO	333	0	0	220	553
RESTRIÇÃO ELÉTRICA	329	160	0	0	489

Na tabela abaixo segue a Indicação de despacho antecipado por ordem de mérito de custo para a semana de 10/07/2021 a 16/07/2021.

Tabela 4 – UTEs com contrato de combustível GNL

UTE			Benefício (R$/MWh)		
Nome	Cod	CVU (R$/MWh)	Carga Pesada	Carga Média	Carga Leve
SANTA CRUZ	86	204,96	754,10 (1)	754,10 (1)	753,54 (1)
LUIZORMELO	15	312,25	754,10 (1)	754,10 (1)	753,54 (1)
PSERGIPE I	224	301,28	244,86 (2)	244,86 (2)	244,85 (2)

(1) Comandado o despacho antecipado por ordem de mérito de custo nesse patamar

(2) NÃO foi comandado o despacho antecipado por ordem de mérito de custo nesse patamar

Assim sendo, há previsão de despacho antecipado por ordem de mérito de custo apenas para as UTE Santa Cruz e Luiz O. R. Melo, para a semana de 10/07 a 16/07/2021.

Embora a UTE Porto Sergipe I não esteja despachada por ordem de mérito de custo, o ONS comanda seu despacho antecipado em sua totalidade, para a semana de 10/07 a 16/07/2021, por garantia energética.

O conteúdo desta publicação foi produzido pelo ONS com base em dados e informações de conhecimento público. É de responsabilidade exclusiva dos agentes e demais interessados a obtenção de outros dados e informações, a realização de análises, estudos e avaliações para fins de tomada de decisões, definição de estratégias de atuação, assunção de compromissos e obrigações e quaisquer outras finalidades, em qualquer tempo e sob qualquer condição. É proibida a reprodução ou utilização total ou parcial do presente sem a identificação da fonte.

8. IMPORTAÇÃO DE ENERGIA DA REPÚBLICA ORIENTAL DO URUGUAI

8.1. República Oriental do Uruguai

Para a próxima semana operativa, foram declaradas as seguintes ofertas de importação de energia da República Oriental do Uruguai para o Sistema Interligado Nacional - SIN através das conversoras de Rivera (70 MW) e Melo (500 MW).

- **Eletrobras**

Tabela 5 – Energia ofertada para importação

	Oferta de Energia para a Semana de 08/05 a 14/05 (MWmed)			
	Bloco 1	Bloco 2	Bloco 3	Total
Carga Pesada	100	50	135	285
Carga Média	100	50	135	285
Carga Leve	100	50	135	285
CVU (R$/MWh)	710,41	911,03	1.037,64	

- **Enel**

Conforme declaração do agente, esta importação poderá ser realizada exclusivamente pela conversora Melo.

Tabela 6 – Energia ofertada para importação

	Oferta de Energia para a Semana de 08/05 a 14/05 (MWmed)			
	Bloco 1	Bloco 2	Bloco 3	Total
Carga Pesada	100	50	135	285
Carga Média	100	50	135	285
Carga Leve	100	50	135	285
CVU (R$/MWh)	723,60	926,14	1.058,35	

8.2. República da Argentina

- **Enel**

Para esta semana operativa, não houve oferta de importação de energia da República da Argentina.

Nota: Detalhes sobre a importação de energia vide Portaria Nº 339, de 15 de agosto de 2018 disponível em: http://pesquisa.in.gov.br/imprensa/jsp/visualiza/index.jsp?data=17/08/2018&jornal=515&pagina=60&totalArquivos=136

O conteúdo desta publicação foi produzido pelo ONS com base em dados e informações de conhecimento público. É de responsabilidade exclusiva dos agentes e demais interessados a obtenção de outros dados e informações, a realização de análises, estudos e avaliações para fins de tomada de decisões, definição de estratégias de atuação, assunção de compromissos e obrigações e quaisquer outras finalidades, em qualquer tempo e sob qualquer condição. É proibida a reprodução ou utilização total ou parcial do presente sem a identificação da fonte.

9. ESTIMATIVA DE ENCARGOS OPERATIVOS

A tabela a seguir apresenta a expectativa do custo de despacho térmico por restrição elétrica para esta semana operativa.

Tabela 7 – Expectativa de custo de despacho térmico por Restrição Elétrica

UTE Potência Instalada (MW)	CVU (R$/MWh)	Geração (MWmed)			ESS ELÉTRICO
		Carga Pesada	Carga Média	Carga Leve	
LUIZORMELO (204)	R$ 312,25	196,0	196,0	196,0	**R$ 4.599.718,20**
T.MACAE (929)	R$ 737,01	10,0	10,0	4,0	**R$ 655.195,80**
VIANA (175)	R$ 946,60	165,8	165,8	75,2	**R$ 15.710.745,15**
TOTAL SE/CO					**R$ 20.965.659,15**

O conteúdo desta publicação foi produzido pelo ONS com base em dados e informações de conhecimento público. É de responsabilidade exclusiva dos agentes e demais interessados a obtenção de outros dados e informações, a realização de análises, estudos e avaliações para fins de tomada de decisões, definição de estratégias de atuação, assunção de compromissos e obrigações e quaisquer outras finalidades, em qualquer tempo e sob qualquer condição. É proibida a reprodução ou utilização total ou parcial do presente sem a identificação da fonte.

10. ARMAZENAMENTOS OPERATIVOS

Para uma melhor avaliação de diversos cenários hidrometeorológicos, notadamente, aqueles de curto prazo e suas influências nas previsões de vazões nos subsistemas, os resultados desta revisão do PMO contemplam cenários de afluências visando melhor representar a ocorrência de precipitação e, consequentemente, seus efeitos sobre as afluências e armazenamentos.

Além dos resultados associados ao valor esperado das previsões de afluências, as simulações operativas também foram realizadas com os limites superior e inferior das previsões de afluências. Apresentamos a seguir os resultados obtidos com a aplicação dos diferentes cenários de afluência.

Tabela 8 – Previsão de ENA dos cenários de sensibilidade

Subsistema	ENERGIAS NATURAIS AFLUENTES					
	Previsão Mensal					
	LI		VE		LS	
	(MWmed)	%MLT	(MWmed)	%MLT	(MWmed)	%MLT
SE/CO	23.325	**58**	25.745	**64**	28.174	**71**
Sul	1.327	**15**	2.154	**25**	3.082	**36**
Nordeste	2.584	**37**	2.796	**40**	3.008	**43**
Norte	15.539	**76**	16.789	**82**	18.037	**88**

Tabela 9 – Previsão de %EARmáx para o final do mês

Subsistema	% EARmáx 07/05	% EARmáx - 31/05		
	NÍVEL INICIAL	NÍVEL PMO		
	VE	LI	VE	LS
SE/CO	33,9	31,0	32,0	33,0
Sul	55,1	52,3	55,7	59,3
Nordeste	66,2	63,1	63,9	64,3
Norte	83,0	83,0	83,7	84,8

O conteúdo desta publicação foi produzido pelo ONS com base em dados e informações de conhecimento público. É de responsabilidade exclusiva dos agentes e demais interessados a obtenção de outros dados e informações, a realização de análises, estudos e avaliações para fins de tomada de decisões, definição de estratégias de atuação, assunção de compromissos e obrigações e quaisquer outras finalidades, em qualquer tempo e sob qualquer condição. É proibida a reprodução ou utilização total ou parcial do presente sem a identificação da fonte.

11. RESERVATÓRIOS EQUIVALENTES DE ENERGIA

A seguir são apresentadas as previsões de Energia Natural Afluente para a próxima semana operativa e para o mês de maio, bem como as previsões de Energia Armazenada nos Reservatórios Equivalentes de Energia – REE, desta Revisão do PMO.

Tabela 10 – Previsão de ENA por REE

Valor Esperado das Energias Naturais Afluentes				
REE	Previsão Semanal		Previsão Mensal	
	08/05/2021 a 14/05/2021		mai/21	
	(MWmed)	%MLT	(MWmed)	%MLT
Sudeste	3.039	66	3.004	65
Madeira	7.972	90	7.763	88
Teles Pires	2.818	137	2.537	123
Itaipu	1.916	55	2.112	60
Paraná	8.513	46	8.741	47
Paranapanema	718	31	811	35
Sul	842	19	1.160	26
Iguaçu	668	16	994	24
Nordeste	2.932	42	2.796	40
Norte	7.079	76	6.653	72
Belo Monte	10.148	108	8.681	93
Manaus	2.141	122	2.026	116

Tabela 11 – Previsão de %EARmáx por REE

% Energia Armazenável Máxima		
REE	Previsão Semanal	Previsão Mensal
	14-mai	31-mai
	(%EARmáx)	(%EARmáx)
Sudeste	42,1	42,0
Madeira	97,6	99,4
Teles Pires	100,0	100,0
Itaipu	13,9	50,1
Paraná	29,4	27,1
Paranapanema	39,3	39,2
Sul	39,0	39,5
Iguaçu	68,4	70,4
Nordeste	65,6	63,9
Norte	84,9	84,1
Belo Monte	83,2	100,0
Manaus	72,4	76,5

O conteúdo desta publicação foi produzido pelo ONS com base em dados e informações de conhecimento público. É de responsabilidade exclusiva dos agentes e demais interessados a obtenção de outros dados e informações, a realização de análises, estudos e avaliações para fins de tomada de decisões, definição de estratégias de atuação, assunção de compromissos e obrigações e quaisquer outras finalidades, em qualquer tempo e sob qualquer condição. É proibida a reprodução ou utilização total ou parcial do presente sem a identificação da fonte.

12. DESPACHO TÉRMICO POR MODALIDADE, PATAMAR DE CARGA E USINA

Nas tabelas abaixo, a diferenciação entre geração por inflexibilidade e por ordem de mérito tem caráter informativo, com o objetivo de detalhar a informação de inflexibilidade enviada pelos respectivos agentes para esta revisão do PMO. Ressalta-se que nas etapas de Programação Diária e Tempo Real, o montante despachado nas usinas termelétricas indicadas por ordem de mérito é plenamente intitulado como ordem de mérito.

REGIÃO SUDESTE/CENTRO-OESTE																	
Térmicas Potência (MW)	Combustível	CVU (R$/MWh)	Inflexibilidade			Ordem de Mérito			Total Mérito e INFL.			Razão Elétrica			Total UTE		
			P	M	L	P	M	L	P	M	L	P	M	L	P	M	L
ATLAN_CSA (255)	Resíduos	0,00															
ANGRA 2 (1350)	Nuclear	20,12	1220,0	1220,0	1220,0	0,0	0,0	0,0	1220,0	1220,0	1220,0				1220,0	1220,0	1220,0
ANGRA 1 (640)	Nuclear	31,17				0,0	0,0	0,0	0,0	0,0	0,0				0,0	0,0	0,0
NORTEFLU 1 (400)	Gás	86,91	400,0	400,0	400,0	0,0	0,0		400,0	400,0	400,0				400,0	400,0	400,0
NORTEFLU 2 (100)	Gás	95,84	100,0	100,0	100,0	0,0	0,0		100,0	100,0	100,0				100,0	100,0	100,0
O.PINTADA (50)	Biomassa	112,47	6,9	6,9	6,9	43,1	43,1		50,0	50,0	6,9				50,0	50,0	6,9
UTE STA VI (41)	Biomassa	121,49	13,0	13,0	13,0	28,4	28,4		41,4	41,4	13,0				41,4	41,4	13,0
NORTEFLU 3 (200)	Gás	186,81	30,0	30,0	30,0	0,0	0,0		30,0	30,0	30,0				30,0	30,0	30,0
ATLANTICO (235)	Resíduos	198,25	168,0	168,0	168,0	0,0	0,0		168,0	168,0	168,0				168,0	168,0	168,0
BAIXADA FL (530)	Gás	201,85				530,0	530,0		530,0	530,0					530,0	530,0	0,0
SANTA CRUZ (500)	GNL	204,96															
T.LAGOAS (350)	Gás	261,87															
JUIZ DE FO (87)	Gás	283,74															
ST.CRUZ 34 (436)	Óleo	310,41															
LUIZORMELO (204)	GNL	312,25										196,0	196,0	196,0	196,0	196,0	196,0
TERMORIO (1036)	Gás	328,43															
CUBATAO (216)	Gás	342,50															
SEROPEDICA (386)	Gás	409,63															
PIRAT.12 O (200)	Gás	470,34															
IBIRITE (226)	Gás	482,95															
NPIRATINGA (572)	Gás	548,04															
NORTEFLU 4 (127)	Gás	586,96															
CUIABA CC (529)	Gás	675,63															
T.MACAE (929)	Gás	737,01										10,0	10,0	4,0	10,0	10,0	4,0
PALMEIR_GO (176)	Diesel	762,05															
TNORTE 2 (340)	Óleo	910,86															
VIANA (175)	Óleo	946,60										165,8	165,8	75,2	165,8	165,8	75,2
CAMPOS (25)	Gás	978,10															
DAIA (44)	Diesel	1018,25															
GOIANIA 2 (140)	Diesel	1064,95															
XAVANTES (54)	Diesel	1463,35															
TOTAL SE/CO (10553)			1937,9	1937,9	1937,9	601,5	601,5	0,0	2539,4	2539,4	1937,9	371,8	371,8	275,2	2911,2	2911,2	2213,1

REGIÃO SUL																	
Térmicas Potência (MW)	Combustível	CVU (R$/MWh)	Inflexibilidade			Ordem de Mérito			Total Mérito e INFL.			Razão Elétrica			Total UTE		
			P	M	L	P	M	L	P	M	L	P	M	L	P	M	L
URUGUAIANA (640)	Gás	0,00															
PAMPA SUL (345)	Carvão	69,75				0,0	0,0	0,0	0,0	0,0	0,0				0,0	0,0	0,0
SAO SEPE (8)	Biomassa	87,75	5,0	5,0	5,0	0,0	0,0		5,0	5,0	5,0				5,0	5,0	5,0
CANDIOTA_3 (350)	Carvão	88,75	325,0	325,0	325,0	0,0	0,0		325,0	325,0	325,0				325,0	325,0	325,0
J.LACER. C (363)	Carvão	206,84				0,0	0,0										
J.LACER. B (262)	Carvão	244,14										160,0	160,0	160,0	160,0	160,0	160,0
J.LAC. A2 (132)	Carvão	245,21															
J.LAC. A1 (100)	Carvão	270,48															
MADEIRA (4)	Biomassa	318,99	2,0	2,0	2,0				2,0	2,0	2,0				2,0	2,0	2,0
FIGUEIRA (20)	Carvão	475,68															
CANOAS (249)	Diesel	698,14															
ARAUCARIA (484)	Gás	936,86															
TOTAL SUL (2957)			332,0	332,0	332,0	0,0	0,0	0,0	332,0	332,0	332,0	160,0	160,0	160,0	492,0	492,0	492,0

O conteúdo desta publicação foi produzido pelo ONS com base em dados e informações de conhecimento público. É de responsabilidade exclusiva dos agentes e demais interessados a obtenção de outros dados e informações, a realização de análises, estudos e avaliações para fins de tomada de decisões, definição de estratégias de atuação, assunção de compromissos e obrigações e quaisquer outras finalidades, em qualquer tempo e sob qualquer condição. É proibida a reprodução ou utilização total ou parcial do presente sem a identificação da fonte.

REGIÃO NORDESTE

Térmicas Potência (MW)	Combustível	CVU (R$/MWh)	Inflexibilidade			Ordem de Mérito			Total Mérito e INFL.			Razão Elétrica			Total UTE		
			P	M	L	P	M	L	P	M	L	P	M	L	P	M	L
ERB CANDEI (17)	Biomassa	87,81	4,5	4,5	4,5				4,5	4,5	4,5				4,5	4,5	4,5
PROSPERIDA (28)	Gás	165,61	28,0	28,0	28,0				28,0	28,0	28,0				28,0	28,0	28,0
TERMOPE (533)	Gás	185,39	532,7	532,7	532,7				532,7	532,7	532,7				532,7	532,7	532,7
P.PECEM1 (720)	Carvão	233,97															
P.PECEM2 (365)	Carvão	241,56															
FORTALEZA (327)	Gás	245,46															
PSERGIPE I (1516)	GNL	301,28															
TERMOCEARA (223)	Gás	429,34															
SYKUE I (30)	Biomassa	510,12															
VALE ACU (368)	Gás	526,79															
T.BAHIA (186)	Gás	537,33															
PERNAMBU_3 (201)	Óleo	816,54															
BAHIA_1 (31)	Óleo	816,92															
ALTOS (13)	Diesel	881,41															
ARACATI (11)	Diesel	881,41															
BATURITE (11)	Diesel	881,41															
C.MAIOR (13)	Diesel	881,41															
CAUCAIA (15)	Diesel	881,41															
CRATO (13)	Diesel	881,41															
IGUATU (15)	Diesel	881,41															
JUAZEIRO N (15)	Diesel	881,41															
MARAMBAIA (13)	Diesel	881,41															
NAZARIA (13)	Diesel	881,41															
PECEM (15)	Diesel	881,41															
MARACANAU (168)	Óleo	920,98															
TERMOCABO (50)	Óleo	934,98															
TERMONE (171)	Óleo	938,29															
TERMOPB (171)	Óleo	938,29															
CAMPINA_GR (169)	Óleo	946,62															
SUAPE II (381)	Óleo	968,43															
POTIGUAR_3 (66)	Diesel	1002,06															
POTIGUAR (53)	Diesel	1002,07															
AREMBEPE (150)	Óleo	1020,68															
MURICY (147)	Óleo	1020,68															
GLOBAL I (149)	Óleo	1072,45															
GLOBAL II (149)	Óleo	1072,45															
PETROLINA (136)	Óleo	1119,84															
PAU FERRO (94)	Diesel	1134,44															
TERMOMANAU (143)	Diesel	1134,44															
TOTAL NE (6889)			565,2	565,2	565,2	0,0	0,0	0,0	565,2	565,2	565,2	0,0	0,0	0,0	565,2	565,2	565,2

REGIÃO NORTE

Térmicas Potência (MW)	Combustível	CVU (R$/MWh)	Inflexibilidade			Ordem de Mérito			Total Mérito e INFL.			Razão Elétrica			Total UTE		
			P	M	L	P	M	L	P	M	L	P	M	L	P	M	L
C. ROCHA (85)	Gás	0,00	65,0	65,0	65,0				65,0	65,0	65,0				65,0	65,0	65,0
JARAQUI (75)	Gás	0,00	63,0	63,0	63,0				63,0	63,0	63,0				63,0	63,0	63,0
MANAUARA (67)	Gás	0,00	64,5	64,5	64,5				64,5	64,5	64,5				64,5	64,5	64,5
PONTA NEGR (66)	Gás	0,00	64,0	64,0	64,0				64,0	64,0	64,0				64,0	64,0	64,0
TAMBAQUI (93)	Gás	0,00	63,0	63,0	63,0				63,0	63,0	63,0				63,0	63,0	63,0
MARANHAO3 (519)	Gás	85,72				0,0	515,3	265,3	0,0	515,3	265,3				0,0	515,3	265,3
APARECIDA (166)	Gás	98,28	75,0	75,0	75,0				75,0	75,0	75,0				75,0	75,0	75,0
UTE MAUA 3 (591)	Gás	98,28	264,0	264,0	264,0				264,0	264,0	264,0				264,0	264,0	264,0
PARNAIB_IV (56)	Gás	151,69															
MARAN_VL_7 (336)	Gás	189,11															
MARAN_VL22 (1)	Gás	189,11															
MARANIVL_7 (336)	Gás	189,11															
MARANIVL22 (1)	Gás	189,11															
N.VEN2_L22 (27)	Gás	232,01															
N.VEN2_L7 (151)	Gás	232,27															
P. ITAQUI (360)	Carvão	235,54															
GERAMAR1 (166)	Óleo	946,58															
GERAMAR2 (166)	Óleo	946,58															
TOTAL NORTE (3264)			658,5	658,5	658,5	0,0	515,3	265,3	658,5	1173,8	923,8	0,0	0,0	0,0	658,5	1173,8	923,8

O conteúdo desta publicação foi produzido pelo ONS com base em dados e informações de conhecimento público. É de responsabilidade exclusiva dos agentes e demais interessados a obtenção de outros dados e informações, a realização de análises, estudos e avaliações para fins de tomada de decisões, definição de estratégias de atuação, assunção de compromissos e obrigações e quaisquer outras finalidades, em qualquer tempo e sob qualquer condição. É proibida a reprodução ou utilização total ou parcial do presente sem a identificação da fonte.