1. APRESENTAÇÃO

Na semana de 15/05 a 21/05/2021 permaneceu a condição de pancadas de chuva no trecho baixo das bacias dos rios Tocantins e Xingu, e nos trechos médio e baixos do rio Madeira. As demais bacias de importância do SIN não apresentaram volumes expressivos durante esta semana operativa.

Na semana de 22/05 a 28/05/2021 a condição de precipitação permanece no trecho baixo das bacias dos rios Tocantins, Xingu e Madeira. Além disso, deve ocorrer chuva fraca na bacia do rio Jacuí e em pontos isolados do Uruguai, Paraná, Iguaçu, Paranapanema e Tietê.

Para a semana operativa de 22/05 a 28/05/2021, houve oferta de energia da República Oriental do Uruguai. De acordo com o Art. 2º da Portaria MME nº 339, de 15 de agosto de 2018, as ofertas para importação de energia não foram consideradas na elaboração do PMO. Para a referida semana, não houve oferta de energia da República da Argentina.

Os valores médios semanais do Custo Marginal de Operação – CMO dos subsistemas do SIN sofreram as seguintes alterações em relação à semana anterior:

- SE/CO: de R$ 220,13/MWh para R$ 287,26/MWh
- Sul: de R$ 220,13/MWh para R$ 287,26/MWh
- Nordeste: de R$ 195,29/MWh para R$ 248,60/MWh
- Norte: de R$ 195,29/MWh para R$ 248,60/MWh

Desde o dia 01/01/2020, o despacho por ordem de mérito é indicado diariamente pelos resultados do modelo DESSEM. Assim, o despacho por ordem de mérito semanal, conforme publicado nesse documento, tem caráter apenas informativo. Da mesma forma, desde o dia 01/01/2021, a formação de preço deixou o formato semanal/patamar de carga e passou a ser horário, de acordo também com os resultados do modelo DESSEM.

2. NOTÍCIAS

Nos dias 27 e 28 de maio será realizada a reunião de elaboração do PMO Junho de 2021, com transmissão ao vivo através do site do ONS.

Como medida adicional de prevenção ao Coronavírus, o ONS informa que está suspensa, temporariamente, a participação presencial nas reuniões.

3. ANÁLISE DAS CONDIÇÕES HIDROMETEOROLÓGICAS

3.1. PREVISÃO PARA A PRÓXIMA SEMANA

A condição de precipitação permanece no trecho baixo das bacias dos rios Tocantins, Xingu e Madeira na próxima semana operativa (**Figura 1**). No início da semana uma nova frente fria avança rapidamente pela região Sul ocasionando chuva fraca na bacia do rio Jacuí e em pontos isolados do Uruguai, Paraná, Iguaçu, Paranapanema e Tietê.

O conteúdo desta publicação foi produzido pelo ONS com base em dados e informações de conhecimento público. É de responsabilidade exclusiva dos agentes e demais interessados a obtenção de outros dados e informações, a realização de análises, estudos e avaliações para fins de tomada de decisões, definição de estratégias de atuação, assunção de compromissos e obrigações e quaisquer outras finalidades, em qualquer tempo e sob qualquer condição. É proibida a reprodução ou utilização total ou parcial do presente sem a identificação da fonte.

Figura 1- Precipitação acumulada prevista pelo modelo ECMWF (ECMWF) para o período de 22/05/2021 a 28/05/2021.

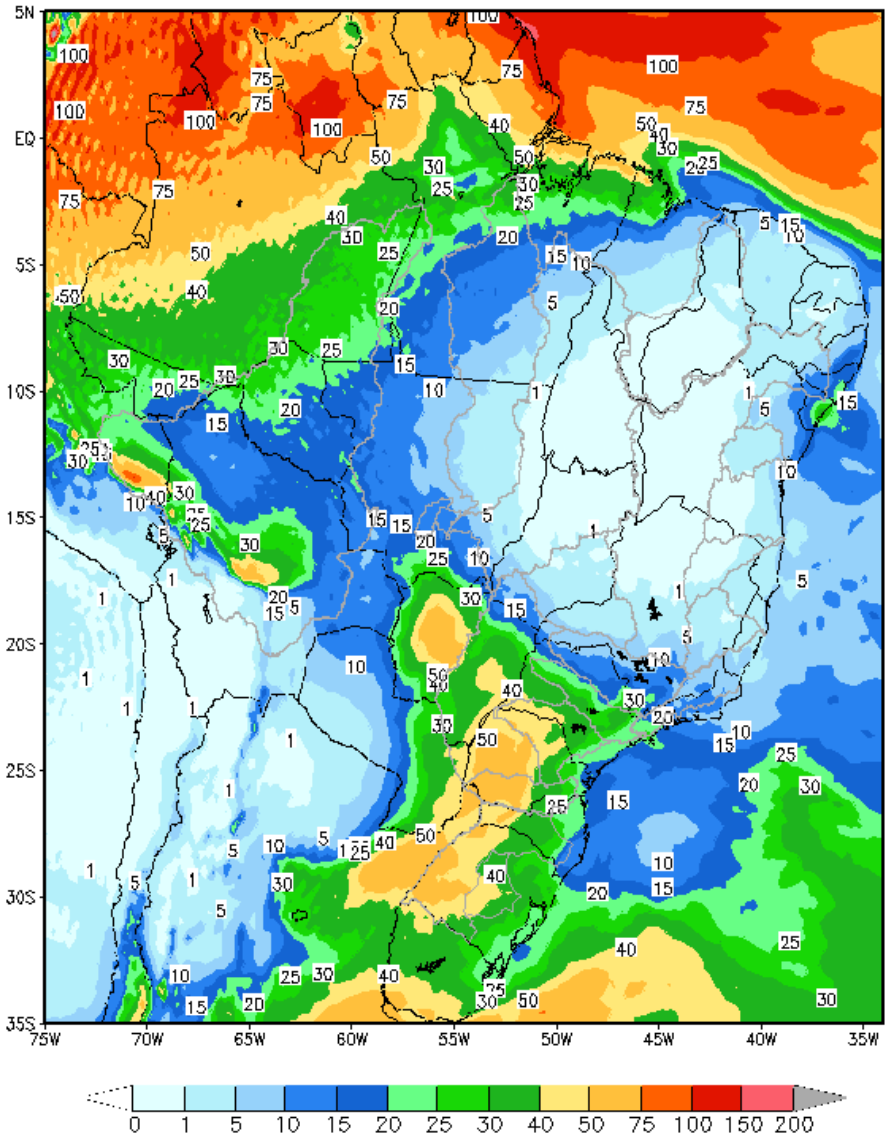

Em comparação com os valores estimados para a semana em curso, prevê-se para a próxima semana operativa recessão nas afluências dos subsistemas Sudeste/Centro-Oeste, Nordeste e Norte e estabilidade nas afluências do subsistema Sul. A previsão mensal para maio indica a ocorrência de afluências abaixo da média histórica para todos os subsistemas.

Tabela 1 – Previsão de ENAs da Revisão 3 de Maio/2021

Revisão 3 do PMO de Maio/2021 - ENAs previstas				
Subsistema	22/05 a 28/05/2021		Mês de maio	
	MWmed	%MLT	MWmed	%MLT
SE/CO	21.830	55	24.476	61
S	1.807	21	1.829	21
NE	2.221	32	2.539	36
N	14.817	73	17.746	87

O conteúdo desta publicação foi produzido pelo ONS com base em dados e informações de conhecimento público. É de responsabilidade exclusiva dos agentes e demais interessados a obtenção de outros dados e informações, a realização de análises, estudos e avaliações para fins de tomada de decisões, definição de estratégias de atuação, assunção de compromissos e obrigações e quaisquer outras finalidades, em qualquer tempo e sob qualquer condição. É proibida a reprodução ou utilização total ou parcial do presente sem a identificação da fonte.

4. PREVISÃO DE CARGA

As medidas restritivas associadas à Covid-19 continuaram impactando negativamente o setor industrial brasileiro em abril, com empresas diminuindo a produção e limitando a compra de insumos, devido a mais um declínio no volume de novos pedidos. Vale lembrar que os meses de abril e maio de 2020 foram os mais impactados pelas medidas restritivas para conter o avanço da COVID 19. A carga do SIN apresentou uma redução de 10,5%, em maio de 2020, quando comparada ao mesmo período de 2019. Esses fatores explicam as expressivas taxas de crescimentos apresentadas pelas projeções de carga dos subsistemas em maio/21.

As previsões meteorológicas indicam para a próxima semana operativa, temperaturas semelhantes às observadas na semana em curso para todas as regiões do Brasil, com os seguintes destaques:

- ✓ Regiões SE/CO e SUL: Expectativa de ocorrência de temperaturas amenas, comportamento típico para essa época do ano.
- ✓ Região Nordeste: Sinalização de ocorrência de totais de precipitação inferiores aos observados nas últimas semanas.
- ✓ Região NORTE: Expectativa de elevados totais de precipitação, assim como os observados na semana atual, com destaque para Manaus e Belém.

As taxas de crescimento previstas para o mês de maio em relação ao mesmo mês do ano anterior, são de 10,8% para os subsistemas Sudeste/Centro-Oeste, 9,8% para o subsistema Sul, 8,8% no Nordeste e 12,0% no subsistema do Norte.

Tabela 2 – Evolução da carga do PMO de maio 2021

Subsistema	CARGA SEMANAL (MWmed)					CARGA MENSAL (MWmed)	
	1ª Sem	2ª Sem	3ª Sem	4ª Sem	5ª Sem	mai/21	Var. (%) mai/21 -> mai/20
SE/CO	38.600	38.300	38.578	38.412	37.138	38.343	10,8%
Sul	11.589	11.312	11.365	11.360	10.838	11.352	9,8%
Nordeste	10.486	10.506	10.875	10.954	10.651	10.700	8,8%
Norte	5.606	5.801	5.981	5.980	5.765	5.835	12,0%
SIN	66.281	65.919	66.799	66.706	64.393	66.231	10,4%

O conteúdo desta publicação foi produzido pelo ONS com base em dados e informações de conhecimento público. É de responsabilidade exclusiva dos agentes e demais interessados a obtenção de outros dados e informações, a realização de análises, estudos e avaliações para fins de tomada de decisões, definição de estratégias de atuação, assunção de compromissos e obrigações e quaisquer outras finalidades, em qualquer tempo e sob qualquer condição. É proibida a reprodução ou utilização total ou parcial do presente sem a identificação da fonte.

5. PRINCIPAIS RESULTADOS

5.1. CUSTO MARGINAL DE OPERAÇÃO (CMO)

A tabela a seguir apresenta o CMO, por subsistema e patamar de carga para próxima semana operativa.

Tabela 3 – CMO por patamar de carga

Patamares de Carga	CMO (R$/MWh)			
	SE/CO	S	NE	N
Pesada	323,25	323,25	250,48	250,48
Média	315,02	315,02	250,48	250,48
Leve	246,26	246,26	246,26	246,26
Média Semanal	287,26	287,26	248,60	248,60

Na figura a seguir é apresentada a evolução do CMO médio semanal ao longo deste PMO.

Figura 2 – Evolução semanal do CMO

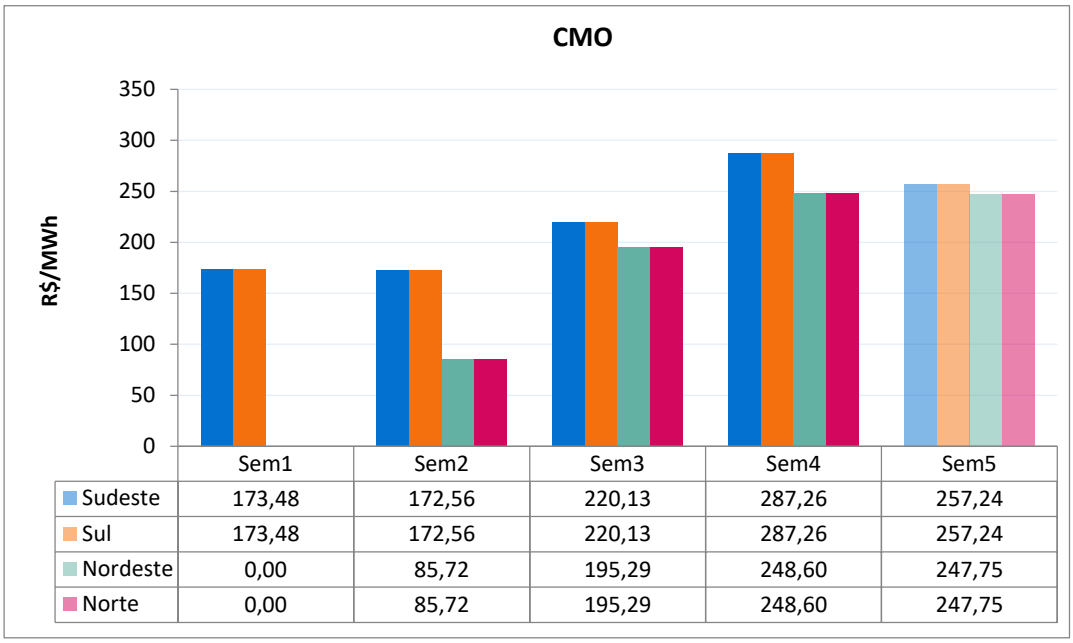

5.2. POLÍTICA DE OPERAÇÃO ENERGÉTICA

Para esta semana operativa, está prevista a seguinte política de intercâmbio de energia entre regiões:

Região SE/CO → Geração minimizada de acordo com os condicionantes hidráulicos.

Região Sul → Geração dimensionada para fechamento do balanço energético do SIN.

Região NE → Aumento da geração eólica e possível exportação de energia, modulando em função de seus recursos energéticos, respeitando-se os limites elétricos vigentes.

Região Norte → Continuidade da exploração das disponibilidades energéticas, respeitando-se os limites elétricos vigentes.

O conteúdo desta publicação foi produzido pelo ONS com base em dados e informações de conhecimento público. É de responsabilidade exclusiva dos agentes e demais interessados a obtenção de outros dados e informações, a realização de análises, estudos e avaliações para fins de tomada de decisões, definição de estratégias de atuação, assunção de compromissos e obrigações e quaisquer outras finalidades, em qualquer tempo e sob qualquer condição. É proibida a reprodução ou utilização total ou parcial do presente sem a identificação da fonte.

6. ANÁLISE DA VARIAÇÃO SEMANAL DO CMO

Esta análise visa identificar os principais parâmetros cujas atualizações impactaram os CMO deste PMO, em comparação com os valores obtidos na última revisão.

Foram realizados 8 estudos, onde o caso inicial foi construído com base nos dados oficiais da última revisão deste PMO. Neste primeiro estudo, denominado de "previsão perfeita", a partida dos reservatórios foi estimada conforme indicado para esta semana na última revisão.

O segundo estudo foi realizado com os dados do caso inicial sendo substituída a previsão de vazões.

A partir do conjunto de dados do segundo estudo foram elaborados os demais casos em que foram atualizados, sequencialmente, as seguintes informações: níveis de partida dos reservatórios, previsão de carga, disponibilidade das usinas térmicas e hidráulicas, restrições de limites de intercâmbio, restrições hidráulicas e, por fim, os demais dados que compõem toda informação referente a atual revisão.

Para os subsistemas Sudeste/Centro-Oeste e Sul, como pode ser observado no resultado do estudo denominado "previsão perfeita", já era prevista a elevação significativa do CMO no patamar de carga leve. Para os patamares de carga pesada e média o principal fator que influenciou na elevação do CMO foi a atualização das restrições hidráulicas.

Para os subsistemas Nordeste e Norte já era prevista a elevação do CMO para essa semana, como pode ser observado no resultado do estudo de "previsão perfeita". Essa tendência de elevação foi intensificada com as atualizações de previsão de vazões, níveis de partida e restrições hidráulicas.

Os custos marginais de operação dos subsistemas Sudeste/Centro-Oeste e Sul estão acoplados e apresentados na Figura 3.

Os custos marginais de operação dos subsistemas Nordeste e Norte estão acoplados e a variação do CMO pode ser vista na Figura 4.

Figura 3 – Análise da variação do CMO nos subsistemas SE/CO e Sul

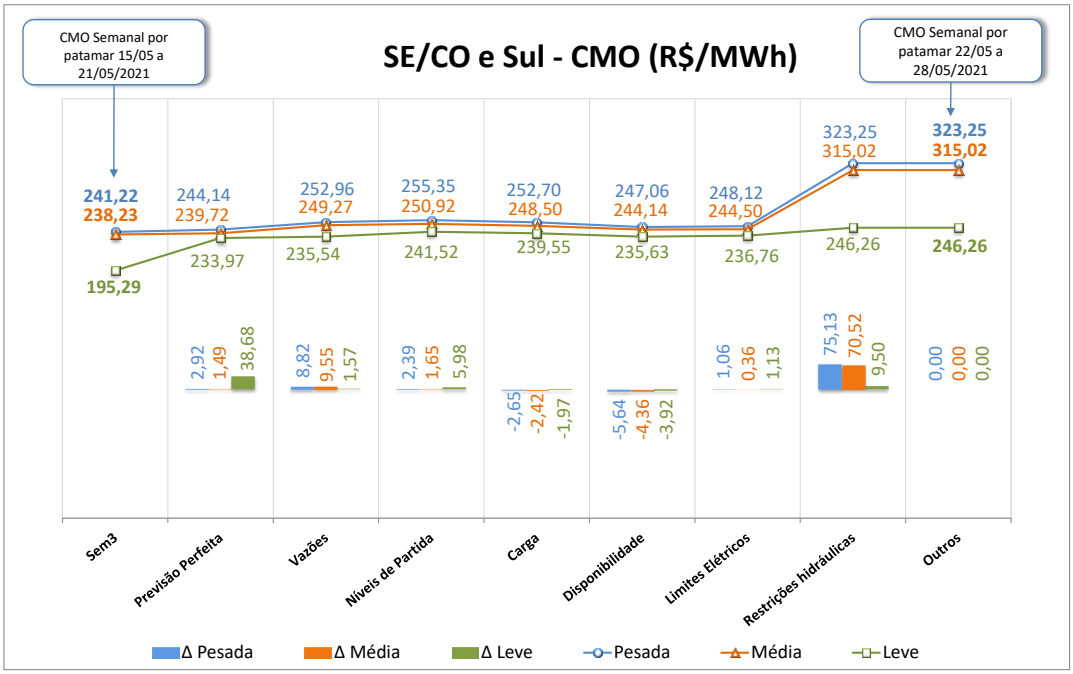

O conteúdo desta publicação foi produzido pelo ONS com base em dados e informações de conhecimento público. É de responsabilidade exclusiva dos agentes e demais interessados a obtenção de outros dados e informações, a realização de análises, estudos e avaliações para fins de tomada de decisões, definição de estratégias de atuação, assunção de compromissos e obrigações e quaisquer outras finalidades, em qualquer tempo e sob qualquer condição. É proibida a reprodução ou utilização total ou parcial do presente sem a identificação da fonte.

Figura 4 – Análise da variação do CMO nos subsistemas Nordeste e Norte

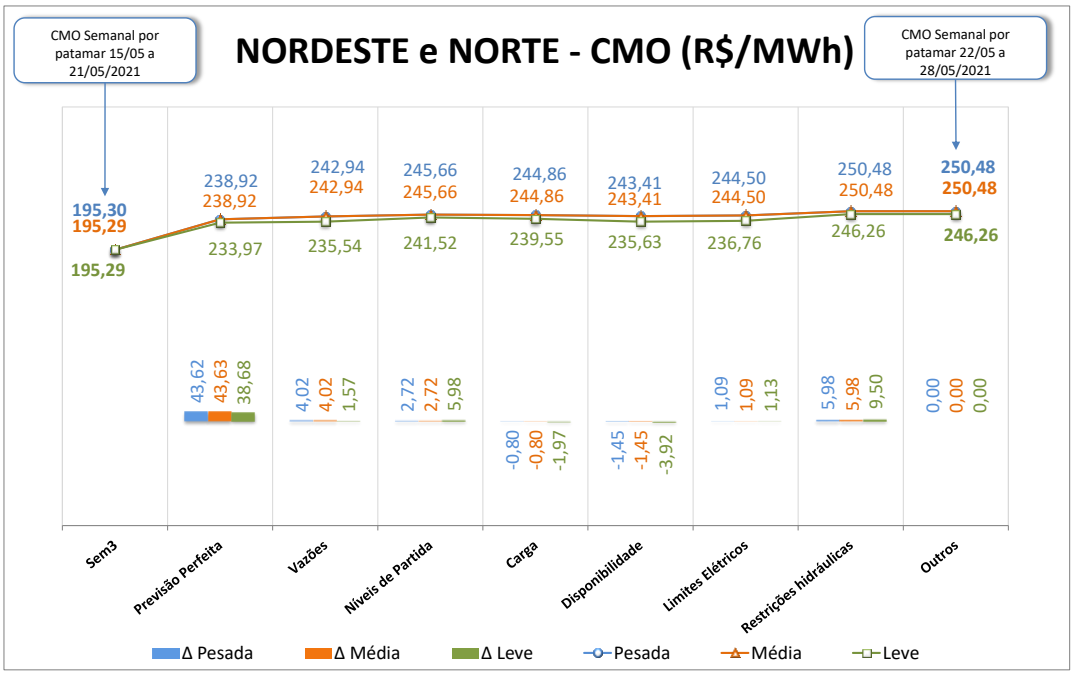

7. GERAÇÃO TÉRMICA

A Figura 5 apresenta, para cada subsistema, o despacho térmico por modalidade indicado pelo DECOMP para a próxima semana operativa.

Figura 5 – Geração térmica para a próxima semana operativa

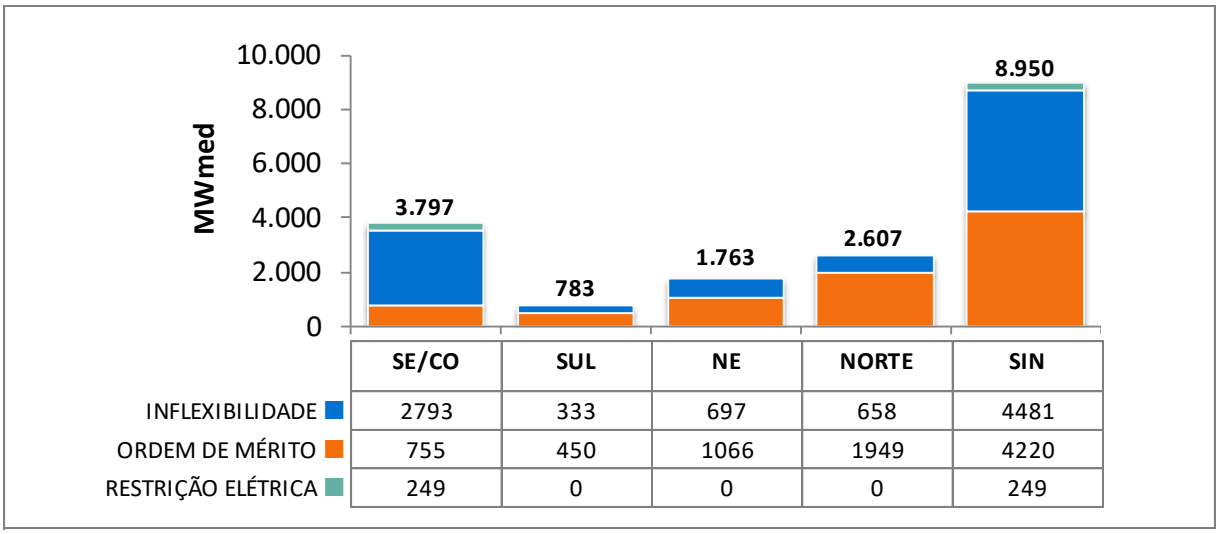

	SE/CO	SUL	NE	NORTE	SIN
INFLEXIBILIDADE	2793	333	697	658	4481
ORDEM DE MÉRITO	755	450	1066	1949	4220
RESTRIÇÃO ELÉTRICA	249	0	0	0	249

O conteúdo desta publicação foi produzido pelo ONS com base em dados e informações de conhecimento público. É de responsabilidade exclusiva dos agentes e demais interessados a obtenção de outros dados e informações, a realização de análises, estudos e avaliações para fins de tomada de decisões, definição de estratégias de atuação, assunção de compromissos e obrigações e quaisquer outras finalidades, em qualquer tempo e sob qualquer condição. É proibida a reprodução ou utilização total ou parcial do presente sem a identificação da fonte.

Na tabela a seguir segue a Indicação de despacho antecipado por ordem de mérito de custo para a semana de 24/07/2021 a 30/07/2021.

Tabela 4 – UTEs com contrato de combustível GNL

UTE			Benefício (R$/MWh)		
Nome	Cod	CVU (R$/MWh)	Carga Pesada	Carga Média	Carga Leve
SANTA CRUZ	86	204,96	804,98 (1)	804,98 (1)	804,39 (1)
LUIZORMELO	15	312,25	804,98 (1)	804,98 (1)	804,39 (1)
PSERGIPE I	224	301,28	249,72 (2)	249,72 (2)	249,72 (2)

(1) Comandado o despacho antecipado por ordem de mérito de custo nesse patamar

(2) NÃO foi comandado o despacho antecipado por ordem de mérito de custo nesse patamar

Assim sendo, há previsão de despacho antecipado por ordem de mérito de custo para as UTE Santa Cruz e Luiz O. R. Melo, para a semana de 24/07 a 30/07/2021.

Embora a UTE Porto Sergipe I não esteja despachada por ordem de mérito de custo, o ONS comanda seu despacho antecipado em sua totalidade, para a semana de 24/07 a 30/07/2021, por garantia energética.

8. IMPORTAÇÃO DE ENERGIA DA REPÚBLICA ORIENTAL DO URUGUAI

8.1. República Oriental do Uruguai

Para a próxima semana operativa, foram declaradas as seguintes ofertas de importação de energia da República Oriental do Uruguai para o Sistema Interligado Nacional - SIN através das conversoras de Rivera (70 MW) e Melo (500 MW).

- **Eletrobras**

Tabela 5 – Energia ofertada para importação

	Oferta de Energia para a Semana de 22/05 a 28/05 (MWmed)			
	Bloco 1	Bloco 2	Bloco 3	Total
Carga Pesada	-	70	225	295
Carga Média	-	70	225	295
Carga Leve	70	-	225	295
CVU (R$/MWh)	486,69	960,06	1.125,22	

O conteúdo desta publicação foi produzido pelo ONS com base em dados e informações de conhecimento público. É de responsabilidade exclusiva dos agentes e demais interessados a obtenção de outros dados e informações, a realização de análises, estudos e avaliações para fins de tomada de decisões, definição de estratégias de atuação, assunção de compromissos e obrigações e quaisquer outras finalidades, em qualquer tempo e sob qualquer condição. É proibida a reprodução ou utilização total ou parcial do presente sem a identificação da fonte.

- **Enel**

Conforme declaração do agente, esta importação poderá ser realizada exclusivamente pela conversora Melo.

Tabela 6 – Energia ofertada para importação

	Oferta de Energia para a Semana de 22/05 a 28/05 (MWmed)			
	Bloco 1	Bloco 2	Bloco 3	Total
Carga Pesada	-	50	225	275
Carga Média	-	50	225	275
Carga Leve	50	-	225	275
CVU (R$/MWh)	489,81	957,84	1.130,04	

8.2. República da Argentina

- **Enel**

Para esta semana operativa, não houve oferta de importação de energia da República da Argentina.

Nota: Detalhes sobre a importação de energia vide Portaria Nº 339, de 15 de agosto de 2018 disponível em: http://pesquisa.in.gov.br/imprensa/jsp/visualiza/index.jsp?data=17/08/2018&jornal=515&pagina=60&totalArquivos=136

9. ESTIMATIVA DE ENCARGOS OPERATIVOS

A tabela a seguir apresenta a expectativa do custo de despacho térmico por restrição elétrica para esta semana operativa.

Tabela 7 – Expectativa de custo de despacho térmico por Restrição Elétrica

UTE Potência Instalada (MW)	CVU (R$/MWh)	Geração (MWmed)			ESS ELÉTRICO
		Carga Pesada	Carga Média	Carga Leve	
LUIZORMELO (204)	R$ 312,25	196,0	196,0	196,0	**R$ 970.053,00**
TERMORIO (1036)	R$ 328,43	80,0	57,6	4,0	**R$ 75.004,73**
VIANA (175)	R$ 946,60	0,0	0,0	24,3	**R$ 1.276.369,63**
TOTAL SE/CO					R$ 2.321.427,35

O conteúdo desta publicação foi produzido pelo ONS com base em dados e informações de conhecimento público. É de responsabilidade exclusiva dos agentes e demais interessados a obtenção de outros dados e informações, a realização de análises, estudos e avaliações para fins de tomada de decisões, definição de estratégias de atuação, assunção de compromissos e obrigações e quaisquer outras finalidades, em qualquer tempo e sob qualquer condição. É proibida a reprodução ou utilização total ou parcial do presente sem a identificação da fonte.

10. ARMAZENAMENTOS OPERATIVOS

Para uma melhor avaliação de diversos cenários hidrometeorológicos, notadamente, aqueles de curto prazo e suas influências nas previsões de vazões nos subsistemas, os resultados desta revisão do PMO contemplam cenários de afluências visando melhor representar a ocorrência de precipitação e, consequentemente, seus efeitos sobre as afluências e armazenamentos.

Além dos resultados associados ao valor esperado das previsões de afluências, as simulações operativas também foram realizadas com os limites superior e inferior das previsões de afluências. Apresentamos a seguir os resultados obtidos com a aplicação dos diferentes cenários de afluência.

Tabela 8 – Previsão de ENA dos cenários de sensibilidade

Subsistema	ENERGIAS NATURAIS AFLUENTES					
	Previsão Mensal					
	LI		VE		LS	
	(MWmed)	%MLT	(MWmed)	%MLT	(MWmed)	%MLT
SE/CO	23.563	**59**	24.476	**61**	25.389	**64**
Sul	1.549	**18**	1.829	**21**	2.106	**24**
Nordeste	2.480	**35**	2.539	**36**	2.598	**37**
Norte	17.281	**85**	17.746	**87**	18.210	**89**

Tabela 9 – Previsão de %EARmáx para o final do mês

Subsistema	% EARmáx 21/05	% EARmáx - 31/05		
	NÍVEL INICIAL	NÍVEL PMO		
	VE	LI	VE	LS
SE/CO	32,6	31,4	31,7	32,1
Sul	55,0	53,6	54,7	56,1
Nordeste	64,6	62,2	63,0	63,4
Norte	83,7	82,8	84,0	84,9

O conteúdo desta publicação foi produzido pelo ONS com base em dados e informações de conhecimento público. É de responsabilidade exclusiva dos agentes e demais interessados a obtenção de outros dados e informações, a realização de análises, estudos e avaliações para fins de tomada de decisões, definição de estratégias de atuação, assunção de compromissos e obrigações e quaisquer outras finalidades, em qualquer tempo e sob qualquer condição. É proibida a reprodução ou utilização total ou parcial do presente sem a identificação da fonte.

11. RESERVATÓRIOS EQUIVALENTES DE ENERGIA

A seguir são apresentadas as previsões de Energia Natural Afluente para a próxima semana operativa e para o mês de maio, bem como as previsões de Energia Armazenada nos Reservatórios Equivalentes de Energia – REE, desta revisão do PMO.

Tabela 10 – Previsão de ENA por REE

Valor Esperado das Energias Naturais Afluentes				
REE	Previsão Semanal		Previsão Mensal	
	22/05/2021 a 28/05/2021		mai/21	
	(MWmed)	%MLT	(MWmed)	%MLT
Sudeste	2.696	59	2.914	63
Madeira	6.638	75	7.692	87
Teles Pires	1.596	78	2.028	99
Itaipu	1.934	55	2.108	60
Paraná	7.506	40	8.143	44
Paranapanema	793	34	815	35
Sul	810	18	913	21
Iguaçu	997	24	916	22
Nordeste	2.221	32	2.539	36
Norte	4.563	49	6.483	70
Belo Monte	7.660	82	9.442	101
Manaus	2.560	146	2.396	137

Tabela 11 – Previsão de %EARmáx por REE

% Energia Armazenável Máxima		
REE	Previsão Semanal	Previsão Mensal
	28-mai	31-mai
	(%EARmáx)	(%EARmáx)
Sudeste	41,7	41,7
Madeira	92,8	94,1
Teles Pires	84,3	90,0
Itaipu	18,1	25,9
Paraná	27,4	27,0
Paranapanema	38,5	38,4
Sul	39,5	39,5
Iguaçu	68,3	68,5
Nordeste	63,5	63,0
Norte	84,4	83,7
Belo Monte	100,0	100,0
Manaus	84,5	87,2

O conteúdo desta publicação foi produzido pelo ONS com base em dados e informações de conhecimento público. É de responsabilidade exclusiva dos agentes e demais interessados a obtenção de outros dados e informações, a realização de análises, estudos e avaliações para fins de tomada de decisões, definição de estratégias de atuação, assunção de compromissos e obrigações e quaisquer outras finalidades, em qualquer tempo e sob qualquer condição. É proibida a reprodução ou utilização total ou parcial do presente sem a identificação da fonte.

12. DESPACHO TÉRMICO POR MODALIDADE, PATAMAR DE CARGA E USINA

Nas tabelas abaixo, a diferenciação entre geração por inflexibilidade e por ordem de mérito tem caráter informativo, com o objetivo de detalhar a informação de inflexibilidade enviada pelos respectivos agentes para esta revisão do PMO. Ressalta-se que nas etapas de Programação Diária e Tempo Real, o montante despachado nas usinas termelétricas indicadas por ordem de mérito é plenamente intitulado como ordem de mérito.

REGIÃO SUDESTE/CENTRO-OESTE

Térmicas Potência (MW)	Combustível	CVU (R$/MWh)	Inflexibilidade			Ordem de Mérito			Total Mérito e INFL.			Razão Elétrica			Total UTE		
			P	M	L	P	M	L	P	M	L	P	M	L	P	M	L
ATLAN_CSA (255)	Resíduos	0,00	20,0	20,0	20,0				20,0	20,0	20,0				20,0	20,0	20,0
ANGRA 2 (1350)	Nuclear	20,12	1220,0	1220,0	1220,0	0,0	0,0	0,0	1220,0	1220,0	1220,0				1220,0	1220,0	1220,0
ANGRA 1 (640)	Nuclear	31,17	640,0	640,0	640,0	0,0	0,0	0,0	640,0	640,0	640,0				640,0	640,0	640,0
NORTEFLU 1 (400)	Gás	86,91	400,0	400,0	400,0	0,0	0,0	0,0	400,0	400,0	400,0				400,0	400,0	400,0
NORTEFLU 2 (100)	Gás	95,84	100,0	100,0	100,0	0,0	0,0	0,0	100,0	100,0	100,0				100,0	100,0	100,0
O.PINTADA (50)	Biomassa	112,47				50,0	50,0	50,0	50,0	50,0	50,0				50,0	50,0	50,0
UTE STA VI (41)	Biomassa	121,49	13,0	13,0	13,0	28,4	28,4	28,4	41,4	41,4	41,4				41,4	41,4	41,4
NORTEFLU 3 (200)	Gás	186,81	200,0	200,0	200,0	0,0	0,0	0,0	200,0	200,0	200,0				200,0	200,0	200,0
ATLANTICO (235)	Resíduos	198,25	200,0	200,0	200,0	0,0	0,0	0,0	200,0	200,0	200,0				200,0	200,0	200,0
BAIXADA FL (530)	Gás	201,85				530,0	530,0	530,0	530,0	530,0	530,0				530,0	530,0	530,0
SANTA CRUZ (500)	GNL	204,96															
T.LAGOAS (350)	Gás	261,87				180,0	180,0		180,0	180,0					180,0	180,0	0,0
JUIZ DE FO (87)	Gás	283,74				84,0	84,0		84,0	84,0					84,0	84,0	0,0
ST.CRUZ 34 (436)	Óleo	310,41															
LUIZORMELO (204)	GNL	312,25										196,0	196,0	196,0	196,0	196,0	196,0
TERMORIO (1036)	Gás	328,43										80,0	57,6	4,0	80,0	57,6	4,0
CUBATAO (216)	Gás	342,50															
SEROPEDICA (386)	Gás	409,63															
PIRAT.12 O (200)	Gás	470,34															
IBIRITE (226)	Gás	482,95															
NPIRATINGA (572)	Gás	548,04															
NORTEFLU 4 (127)	Gás	586,96															
CUIABA CC (529)	Gás	675,63															
T.MACAE (929)	Gás	737,01															
PALMEIR_GO (176)	Diesel	762,05															
TNORTE 2 (340)	Óleo	910,86															
VIANA (175)	Óleo	946,60												24,3	0,0	0,0	24,3
CAMPOS (25)	Gás	978,10															
DAIA (44)	Diesel	1018,25															
GOIANIA 2 (140)	Diesel	1064,95															
XAVANTES (54)	Diesel	1463,35															
TOTAL SE/CO (10553)			2793,0	2793,0	2793,0	872,4	872,4	608,4	3665,4	3665,4	3401,4	276,0	253,6	224,3	3941,4	3919,0	3625,7

REGIÃO SUL

Térmicas Potência (MW)	Combustível	CVU (R$/MWh)	Inflexibilidade			Ordem de Mérito			Total Mérito e INFL.			Razão Elétrica			Total UTE		
			P	M	L	P	M	L	P	M	L	P	M	L	P	M	L
URUGUAIANA (640)	Gás	0,00															
PAMPA SUL (345)	Carvão	69,75				0,0	0,0	0,0	0,0	0,0	0,0				0,0	0,0	0,0
SAO SEPE (8)	Biomassa	87,75	6,0	6,0	6,0	0,0	0,0	0,0	6,0	6,0	6,0				6,0	6,0	6,0
CANDIOTA_3 (350)	Carvão	88,75	325,0	325,0	325,0	0,0	0,0	0,0	325,0	325,0	325,0				325,0	325,0	325,0
J.LACER. C (363)	Carvão	206,84				0,0	0,0	0,0	0,0	0,0	0,0				0,0	0,0	0,0
J.LACER. B (262)	Carvão	244,14				262,0	262,0	262,0	262,0	262,0	262,0				262,0	262,0	262,0
J.LAC. A2 (132)	Carvão	245,21				132,0	132,0	132,0	132,0	132,0	132,0				132,0	132,0	132,0
J.LAC. A1 (100)	Carvão	270,48				100,0	100,0		100,0	100,0					100,0	100,0	0,0
MADEIRA (4)	Biomassa	318,99	2,0	2,0	2,0	1,0			3,0	2,0	2,0				3,0	2,0	2,0
FIGUEIRA (20)	Carvão	475,68															
CANOAS (249)	Diesel	698,14															
ARAUCARIA (484)	Gás	936,86															
TOTAL SUL (2957)			333,0	333,0	333,0	495,0	494,0	394,0	828,0	827,0	727,0	0,0	0,0	0,0	828,0	827,0	727,0

O conteúdo desta publicação foi produzido pelo ONS com base em dados e informações de conhecimento público. É de responsabilidade exclusiva dos agentes e demais interessados a obtenção de outros dados e informações, a realização de análises, estudos e avaliações para fins de tomada de decisões, definição de estratégias de atuação, assunção de compromissos e obrigações e quaisquer outras finalidades, em qualquer tempo e sob qualquer condição. É proibida a reprodução ou utilização total ou parcial do presente sem a identificação da fonte.

REGIÃO NORDESTE

Térmicas Potência (MW)	Combustível	CVU (R$/MWh)	Inflexibilidade			Ordem de Mérito			Total Mérito e INFL.			Razão Elétrica			Total UTE		
			P	M	L	P	M	L	P	M	L	P	M	L	P	M	L
ERB CANDEI (17)	Biomassa	87,81	4,5	4,5	4,5	6,5	6,5	6,5	11,0	11,0	11,0				11,0	11,0	11,0
PROSPERIDA (28)	Gás	165,61	28,0	28,0	28,0	0,0	0,0	0,0	28,0	28,0	28,0				28,0	28,0	28,0
TERMOPE (533)	Gás	185,39	532,7	532,7	532,7	0,0	0,0	0,0	532,7	532,7	532,7				532,7	532,7	532,7
P.PECEM1 (720)	Carvão	233,97				367,5	367,5	367,5	367,5	367,5	367,5				367,5	367,5	367,5
P.PECEM2 (365)	Carvão	241,56				365,0	365,0	365,0	365,0	365,0	365,0				365,0	365,0	365,0
FORTALEZA (327)	Gás	245,46				326,6	326,6	326,6	326,6	326,6	326,6				326,6	326,6	326,6
PSERGIPE I (1516)	GNL	301,28															
TERMOCEARA (223)	Gás	429,34															
SYKUE I (30)	Biomassa	510,12															
VALE ACU (368)	Gás	526,79	22,0	43,3	76,3				22,0	43,3	76,3				22,0	43,3	76,3
T.BAHIA (186)	Gás	537,33	32,0	63,0	129,2				32,0	63,0	129,2				32,0	63,0	129,2
PERNAMBU_3 (201)	Óleo	816,54															
BAHIA_1 (31)	Óleo	816,92															
ALTOS (13)	Diesel	881,41															
ARACATI (11)	Diesel	881,41															
BATURITE (11)	Diesel	881,41															
C.MAIOR (13)	Diesel	881,41															
CAUCAIA (15)	Diesel	881,41															
CRATO (13)	Diesel	881,41															
IGUATU (15)	Diesel	881,41															
JUAZEIRO N (15)	Diesel	881,41															
MARAMBAIA (13)	Diesel	881,41															
NAZARIA (13)	Diesel	881,41															
PECEM (15)	Diesel	881,41															
MARACANAU (168)	Óleo	920,98															
TERMOCABO (50)	Óleo	934,98															
TERMONE (171)	Óleo	938,29															
TERMOPB (171)	Óleo	938,29															
CAMPINA_GR (169)	Óleo	946,62															
SUAPE II (381)	Óleo	968,43															
POTIGUAR_3 (66)	Diesel	1002,06															
POTIGUAR (53)	Diesel	1002,07															
AREMBEPE (150)	Óleo	1020,68															
MURICY (147)	Óleo	1020,68															
GLOBAL I (149)	Óleo	1072,45															
GLOBAL II (149)	Óleo	1072,45															
PETROLINA (136)	Óleo	1119,84															
PAU FERRO (94)	Diesel	1134,44															
TERMOMANAU (143)	Diesel	1134,44															
TOTAL NE (6889)			619,2	671,5	770,7	1065,6	1065,6	1065,6	1684,8	1737,1	1836,3	0,0	0,0	0,0	1684,8	1737,1	1836,3

REGIÃO NORTE

Térmicas Potência (MW)	Combustível	CVU (R$/MWh)	Inflexibilidade			Ordem de Mérito			Total Mérito e INFL.			Razão Elétrica			Total UTE		
			P	M	L	P	M	L	P	M	L	P	M	L	P	M	L
C. ROCHA (85)	Gás	0,00	65,0	65,0	65,0				65,0	65,0	65,0				65,0	65,0	65,0
JARAQUI (75)	Gás	0,00	63,0	63,0	63,0				63,0	63,0	63,0				63,0	63,0	63,0
MANAUARA (67)	Gás	0,00	64,5	64,5	64,5				64,5	64,5	64,5				64,5	64,5	64,5
PONTA NEGR (66)	Gás	0,00	64,0	64,0	64,0				64,0	64,0	64,0				64,0	64,0	64,0
TAMBAQUI (93)	Gás	0,00	63,0	63,0	63,0				63,0	63,0	63,0				63,0	63,0	63,0
MARANHAO3 (519)	Gás	85,72				494,8	515,3	512,7	494,8	515,3	512,7				494,8	515,3	512,7
APARECIDA (166)	Gás	98,28	75,0	75,0	75,0	91,0	91,0	89,2	166,0	166,0	164,2				166,0	166,0	164,2
UTE MAUA 3 (591)	Gás	98,28	264,0	264,0	264,0	115,1	115,1	115,1	379,1	379,1	379,1				379,1	379,1	379,1
PARNAIB_IV (56)	Gás	151,69				37,5	37,5	37,5	37,5	37,5	37,5				37,5	37,5	37,5
MARAN_VL_7 (336)	Gás	189,11				326,0	334,9	333,8	326,0	334,9	333,8				326,0	334,9	333,8
MARAN_VL22 (1)	Gás	189,11				1,1	1,1	1,1	1,1	1,1	1,1				1,1	1,1	1,1
MARANIVL_7 (336)	Gás	189,11				325,9	334,9	333,7	325,9	334,9	333,7				325,9	334,9	333,7
MARANIVL22 (1)	Gás	189,11				1,1	1,1	1,1	1,1	1,1	1,1				1,1	1,1	1,1
N.VEN2_L22 (27)	Gás	232,01				27,0	27,0	27,0	27,0	27,0	27,0				27,0	27,0	27,0
N.VEN2_L7 (151)	Gás	232,27				144,4	150,2	149,4	144,4	150,2	149,4				144,4	150,2	149,4
P. ITAQUI (360)	Carvão	235,54				360,1	360,1	360,1	360,1	360,1	360,1				360,1	360,1	360,1
GERAMAR1 (166)	Óleo	946,58															
GERAMAR2 (166)	Óleo	946,58															
TOTAL NORTE (3264)			658,5	658,5	658,5	1924,0	1968,2	1960,7	2582,5	2626,7	2619,2	0,0	0,0	0,0	2582,5	2626,7	2619,2

O conteúdo desta publicação foi produzido pelo ONS com base em dados e informações de conhecimento público. É de responsabilidade exclusiva dos agentes e demais interessados a obtenção de outros dados e informações, a realização de análises, estudos e avaliações para fins de tomada de decisões, definição de estratégias de atuação, assunção de compromissos e obrigações e quaisquer outras finalidades, em qualquer tempo e sob qualquer condição. É proibida a reprodução ou utilização total ou parcial do presente sem a identificação da fonte.