1. APRESENTAÇÃO

No mês de maio os maiores totais de precipitação ficaram restritos às regiões Sul e Norte do País, atingindo as bacias dos rios Jacuí, Uruguai e ao trecho baixo do Tocantins e do Xingu. Entretanto, apenas a bacia do rio Jacuí apresenta anomalia positiva de chuva. Nas demais bacias hidrográficas de interesse do SIN, o total acumulado do mês está abaixo da média histórica.

No início da semana de 29/05 a 04/06/2021 devem ocorrer totais elevados de precipitação nas bacias dos rios Jacuí, Uruguai e chuva fraca no Iguaçu. Também é esperada a ocorrência de chuva fraca nas bacias dos rios Paranapanema, Tietê, Paraíba do Sul, na incremental a UHE Itaipu e em pontos isolados do Iguaçu e do Grande.

Para a semana operativa de 29/05 a 04/06/2021, não houve oferta de energia da República Oriental do Uruguai, bem como da República da Argentina. De acordo com o Art. 2º da Portaria MME nº 339, de 15 de agosto de 2018, as ofertas para importação de energia não foram consideradas na elaboração do PMO.

Os valores médios semanais do Custo Marginal de Operação – CMO dos subsistemas do SIN sofreram as seguintes alterações em relação à semana anterior:

- SE/CO: de R$ 287,26/MWh para R$ 325,11/MWh
- Sul: de R$ 287,26/MWh para R$ 325,11/MWh
- Nordeste: de R$ 248,60/MWh para R$ 280,83/MWh
- Norte: de R$ 248,60/MWh para R$ 280,83/MWh

Desde o dia 01/01/2020, o despacho por ordem de mérito é indicado diariamente pelos resultados do modelo DESSEM. Assim, o despacho por ordem de mérito semanal, conforme publicado nesse documento, tem caráter apenas informativo. Da mesma forma, desde o dia 01/01/2021, a formação de preço deixou o formato semanal/patamar de carga e passou a ser horário, de acordo também com os resultados do modelo DESSEM.

2. NOTÍCIAS

Nos dias 24 e 25 de junho será realizada a reunião de elaboração do PMO Julho de 2021, com transmissão ao vivo através do site do ONS.

Como medida adicional de prevenção ao Coronavírus, o ONS informa que está suspensa, temporariamente, a participação presencial nas reuniões.

O conteúdo desta publicação foi produzido pelo ONS com base em dados e informações de conhecimento público. É de responsabilidade exclusiva dos agentes e demais interessados a obtenção de outros dados e informações, a realização de análises, estudos e avaliações para fins de tomada de decisões, definição de estratégias de atuação, assunção de compromissos e obrigações e quaisquer outras finalidades, em qualquer tempo e sob qualquer condição. É proibida a reprodução ou utilização total ou parcial do presente sem a identificação da fonte.

3. INFORMAÇÕES PARA ESTUDOS ENERGÉTICOS DE MÉDIO PRAZO - CONSTRUÇÃO DA FUNÇÃO DE CUSTO FUTURO

A atualização de dados para os estudos energéticos de médio prazo é realizada mensalmente quando da elaboração do PMO, tendo por base as informações fornecidas pela ANEEL, MME, EPE, CCEE e Agentes, além de diversas áreas do ONS.

3.1. ATUALIZAÇÃO DAS INFORMAÇÕES ESTRUTURAIS

3.1.1. Oferta

Nas **Figura 1**, **Figura 2** e **Figura 3**, a seguir, são apresentadas as evoluções da oferta hidroelétrica, termoelétrica e da disponibilidade das usinas não simuladas individualmente, respectivamente, em comparação ao PMO de maio/2021, identificando eventuais atrasos ou antecipações de cronograma feitos na reunião de acompanhamento do Departamento de Monitoramento do Setor Elétrico – DMSE/MME, realizada em 20/05/2021.

Figura 1 - Evolução da potência instalada das UHEs

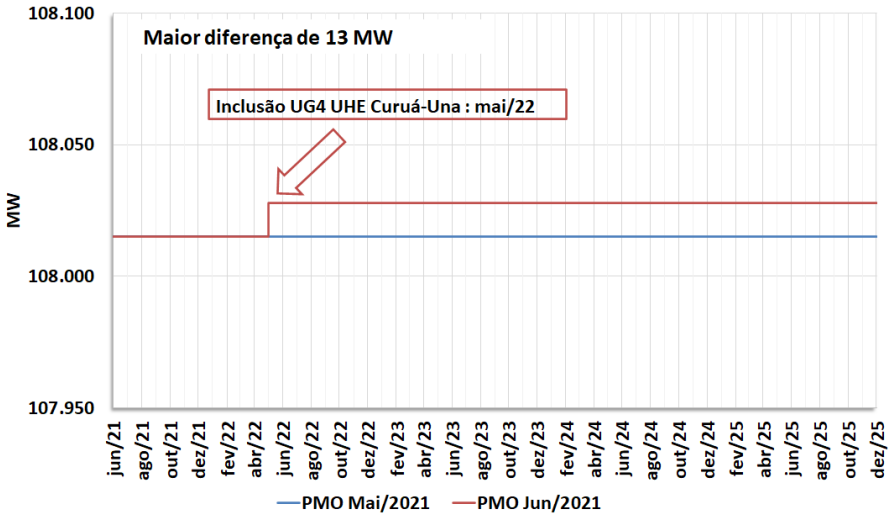

Figura 2 - Evolução da potência instalada das UTEs

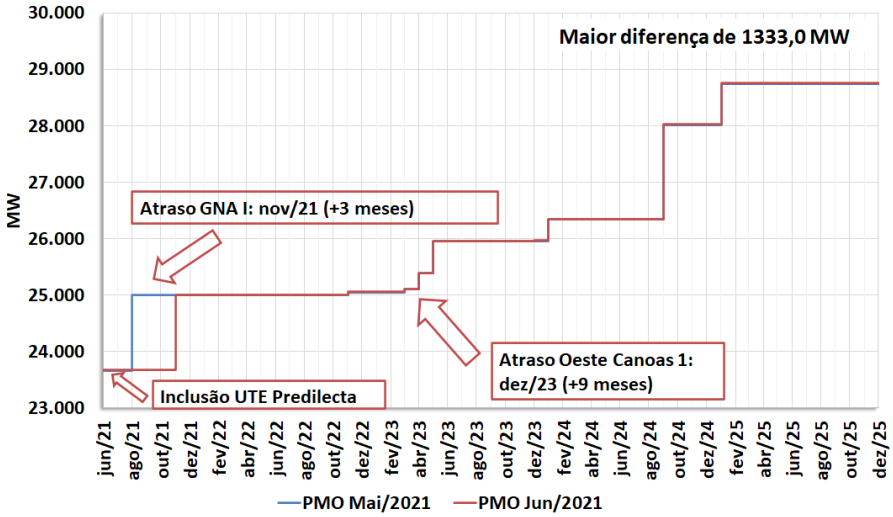

O conteúdo desta publicação foi produzido pelo ONS com base em dados e informações de conhecimento público. É de responsabilidade exclusiva dos agentes e demais interessados a obtenção de outros dados e informações, a realização de análises, estudos e avaliações para fins de tomada de decisões, definição de estratégias de atuação, assunção de compromissos e obrigações e quaisquer outras finalidades, em qualquer tempo e sob qualquer condição. É proibida a reprodução ou utilização total ou parcial do presente sem a identificação da fonte.

Figura 3 - Evolução da disponibilidade das usinas não simuladas

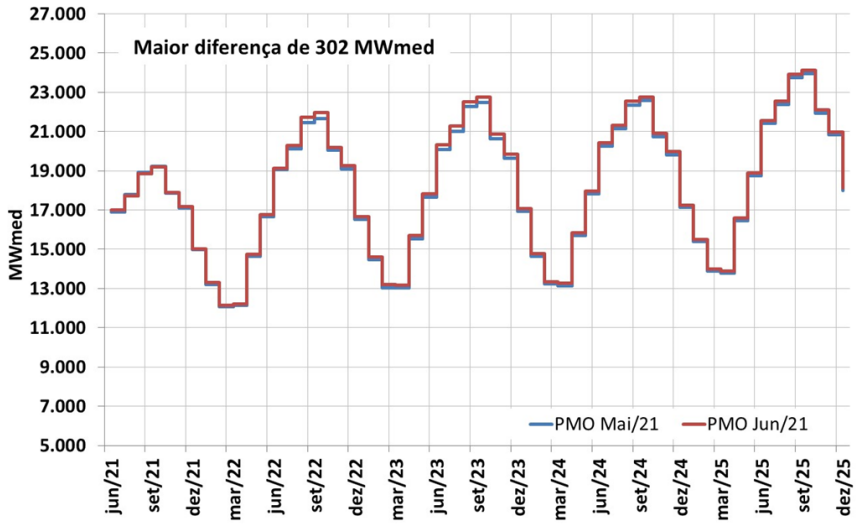

3.1.2. Armazenamentos Iniciais

Na **Figura 4**, a seguir, são apresentados os armazenamentos iniciais equivalentes por subsistema, considerados nos modelos de otimização para a elaboração do PMO de Junho/2021, comparados com os do PMO de Maio/2021.

Figura 4 - Energia armazenada inicial em maio/21 e junho/21 – [% EARmáx]

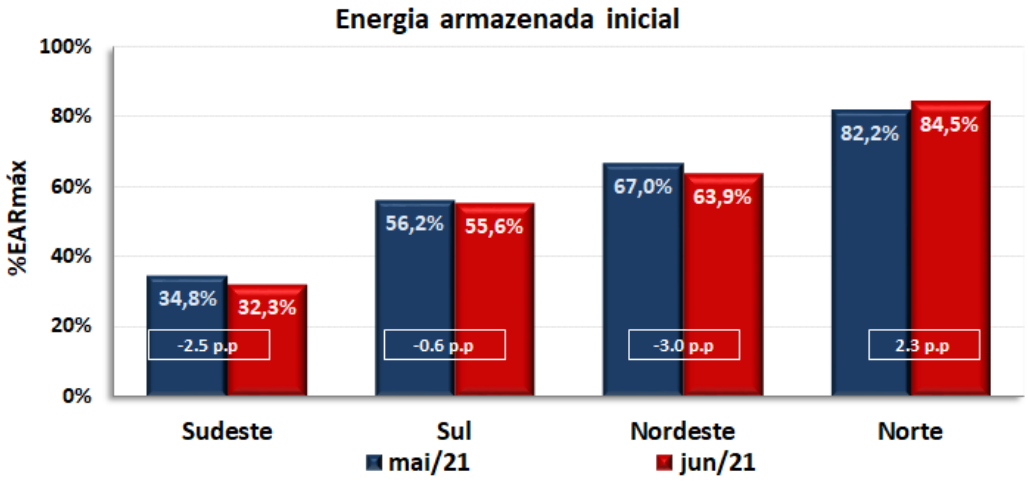

O conteúdo desta publicação foi produzido pelo ONS com base em dados e informações de conhecimento público. É de responsabilidade exclusiva dos agentes e demais interessados a obtenção de outros dados e informações, a realização de análises, estudos e avaliações para fins de tomada de decisões, definição de estratégias de atuação, assunção de compromissos e obrigações e quaisquer outras finalidades, em qualquer tempo e sob qualquer condição. É proibida a reprodução ou utilização total ou parcial do presente sem a identificação da fonte.

3.1.3. Tendência Hidrológica

Na Tabela 1, a seguir, são apresentadas as tendências hidrológicas consideradas pelo modelo NEWAVE para o PMO de junho/2021, comparadas com o PMO de maio/2021.

Tabela 1 – Tendência hidrológica para o PMO de junho/2021 – NEWAVE [%MLT]

	PMO maio/2021				PMO junho/2021			
MÊS	SE/CO	S	NE	N	SE/CO	S	NE	N
nov/20	61	22	87	88				
dez/20	64	94	47	56	64	94	47	54
jan/21	71	154	47	56	70	154	47	54
fev/21	74	122	42	73	73	122	42	71
mar/21	76	69	70	113	75	69	70	110
abr/21	65	35	35	90	64	35	35	88
mai/21					63	25	37	88

* ≥100% MLT < 100% MLT

3.2. DEMAIS ATUALIZAÇÕES

Adicionalmente, neste PMO ocorreram os seguintes destaques:

- Horizonte de estudo: junho de 2021 a dezembro de 2025;
- Cronograma de Obras – Reunião DMSE-G de 20/05/2021;
- CVUs de UTEs vendedoras em leilão;
- CVU das UTEs Termopernambuco e NorteFluminense 1, 2, 3, 4, conforme Despachos SRG/ANEEL nº 1.480/2021 e 1.500/2021;
- UTE Araucária modelada com CVU válido até abril/2022, conforme Despacho SRG/ANEEL nº 1.493/2021. Disponibilidade válida até dezembro/2021, conforme Despacho SFG/ANEEL nº 3.630/2020 e compatibilizada com as informações de curto prazo. Disponibilidade nula de janeiro/2022 até o final do horizonte de simulação;
- Mudança de modalidade da UTE Predilecta para Tipo II-A (Simulada individualmente) conforme DAPR/D_ONS/26/5/2021 e modelagem conforme Carta ONS nº 1.009/DPL/PE/2021;
- Alterações de restrições operativas para as UHEs Batalha, Caconde, Chavantes, Jupiá, P. Primavera, A. A. Laydner, Peixe Angical, Serra da Mesa e Salto Osório, de acordo com os FSAR-H enviados pelos Agentes responsáveis;
- Alteração de dados cadastrais da UHE Curuá-Una devido à inclusão da UG 04 na expansão na reunião do DMSE-G, conforme Carta ONS nº 0927/DPL/PE/2021 e Ofício SRG/ANEEL nº 027/2021;
- Pequenos ajustes nos fatores e montantes existentes das Usinas Não Simuladas Individualmente
  (PCT no Sudeste/Centro-Oeste, PCH no Sul, PCH e EOL no Nordeste);

O conteúdo desta publicação foi produzido pelo ONS com base em dados e informações de conhecimento público. É de responsabilidade exclusiva dos agentes e demais interessados a obtenção de outros dados e informações, a realização de análises, estudos e avaliações para fins de tomada de decisões, definição de estratégias de atuação, assunção de compromissos e obrigações e quaisquer outras finalidades, em qualquer tempo e sob qualquer condição. É proibida a reprodução ou utilização total ou parcial do presente sem a identificação da fonte.

- Restrições de defluências das usinas do Rio São Francisco conforme "Informe Sobre o Planejamento e a Programação da Operação dos Aproveitamentos Hidroelétricos da Bacia do Rio São Francisco no PMO de Junho de 2021";
- Atualização dos limites de transmissão entre subsistemas, para os meses de junho e julho de 2021.
-

4. ANÁLISE DAS CONDIÇÕES HIDROMETEOROLÓGICAS

No início da próxima semana uma nova frente fria avança rapidamente pelas regiões Sul e Sudeste/Centro-Oeste ocasionando totais elevados de precipitação nas bacias dos rios Jacuí, Uruguai e chuva fraca no Iguaçu (Figura 5). A atuação de áreas de instabilidade sobre os estados do Paraná, Mato Grosso do Sul, São Paulo e do Rio de Janeiro ocasiona chuva fraca nas bacias dos rios Paranapanema, Tietê, Paraíba do Sul, na incremental a UHE Itaipu e em pontos isolados do Iguaçu e do Grande.

Figura 5 - Precipitação acumulada prevista pelo modelo ECMWF (ECMWF) para o período de 29/05/2021 a 04/06/2021.

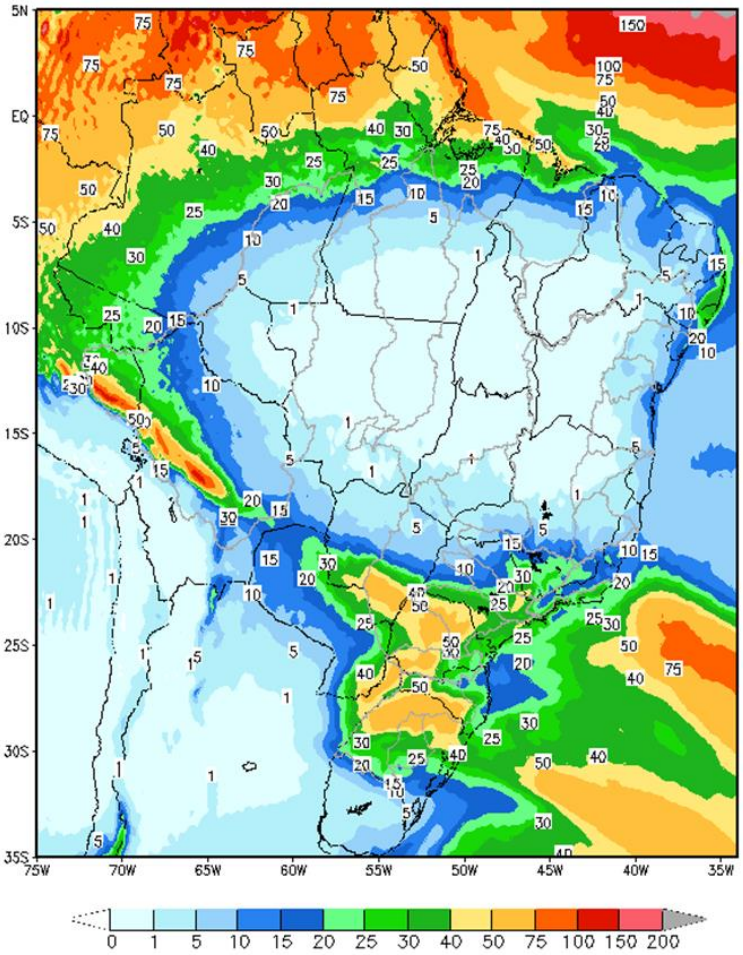

Em comparação com os valores estimados para a semana em curso, prevê-se para a próxima semana operativa ascensão nas afluências dos subsistemas sul, nordeste e norte e recessão nas afluências do subsistema sudeste. A previsão mensal para junho indica a ocorrência de afluências abaixo da média histórica para todos os subsistemas.

O conteúdo desta publicação foi produzido pelo ONS com base em dados e informações de conhecimento público. É de responsabilidade exclusiva dos agentes e demais interessados a obtenção de outros dados e informações, a realização de análises, estudos e avaliações para fins de tomada de decisões, definição de estratégias de atuação, assunção de compromissos e obrigações e quaisquer outras finalidades, em qualquer tempo e sob qualquer condição. É proibida a reprodução ou utilização total ou parcial do presente sem a identificação da fonte.

Tabela 2 – Previsão de ENAs do PMO de Junho/2021

PMO de Junho/2021 - ENAs previstas				
Subsistema	29/05 a 04/06/2021		Mês de junho	
	MWmed	%MLT	MWmed	%MLT
SE/CO	21.859	61	20.414	63
S	3.325	34	5.626	54
NE	2.034	36	1.748	38
N	11.354	76	8.199	77

5. PREVISÃO DE CARGA

Para o mês de junho/21 as previsões de carga consolidadas levaram em consideração a melhorias das expectativas para o próximo semestre. Segundo a FGV - Fundação Getúlio Vargas, o avanço da vacinação, ainda que em ritmo lento, e a ampliação das exportações devido a maior demanda externa são fatores que estão contribuindo para a melhora dessas expectativas.

Para a próxima semana operativa as previsões meteorológicas indicam, temperaturas semelhantes às observadas na semana em curso para todas as regiões do Brasil. Destaca-se a sinalização de ocorrência de temperaturas amenas, comportamento típico para essa época do ano, nos subsistemas Sudeste/Centro-Oeste e Sul e para o subsistema Norte a expectativa é de ocorrência de elevados totais de precipitação.

As taxas de crescimento previstas para o mês de maio em relação ao mesmo mês do ano anterior, são de 6,3% para os subsistemas Sudeste/Centro-Oeste, 5,7% para o subsistema Sul, 7,7% no Nordeste e 8,8% no subsistema do Norte.

Tabela 3 – Evolução da carga do PMO de Junho 2021

Subsistema	CARGA SEMANAL (MWmed)					CARGA MENSAL (MWmed)	
	1ª Sem	2ª Sem	3ª Sem	4ª Sem	5ª Sem	jun/21	Var. (%) jun/21 -> jun/20
SE/CO	37.727	38.553	38.291	37.840	37.292	38.005	6,3%
Sul	10.770	11.371	11.404	11.413	11.423	11.317	5,7%
Nordeste	10.573	10.916	10.781	10.434	10.261	10.617	7,7%
Norte	5.841	5.952	5.894	5.783	5.758	5.852	8,8%
SIN	64.911	66.792	66.370	65.470	64.734	65.791	6,6%

O conteúdo desta publicação foi produzido pelo ONS com base em dados e informações de conhecimento público. É de responsabilidade exclusiva dos agentes e demais interessados a obtenção de outros dados e informações, a realização de análises, estudos e avaliações para fins de tomada de decisões, definição de estratégias de atuação, assunção de compromissos e obrigações e quaisquer outras finalidades, em qualquer tempo e sob qualquer condição. É proibida a reprodução ou utilização total ou parcial do presente sem a identificação da fonte.

6. PRINCIPAIS RESULTADOS

6.1. CUSTO MARGINAL DE OPERAÇÃO (CMO)

A tabela a seguir apresenta o CMO, por subsistema e patamar de carga para próxima semana operativa.

Tabela 4 – CMO por patamar de carga

Patamares de Carga	CMO (R$/MWh)			
	SE/CO	S	NE	N
Pesada	346,09	346,09	280,83	280,83
Média	340,53	340,53	280,83	280,83
Leve	308,06	308,06	280,83	280,83
Média Semanal	325,11	325,11	280,83	280,83

Na figura a seguir é apresentada a evolução do CMO médio semanal ao longo deste PMO.

Figura 6 – Evolução semanal do CMO

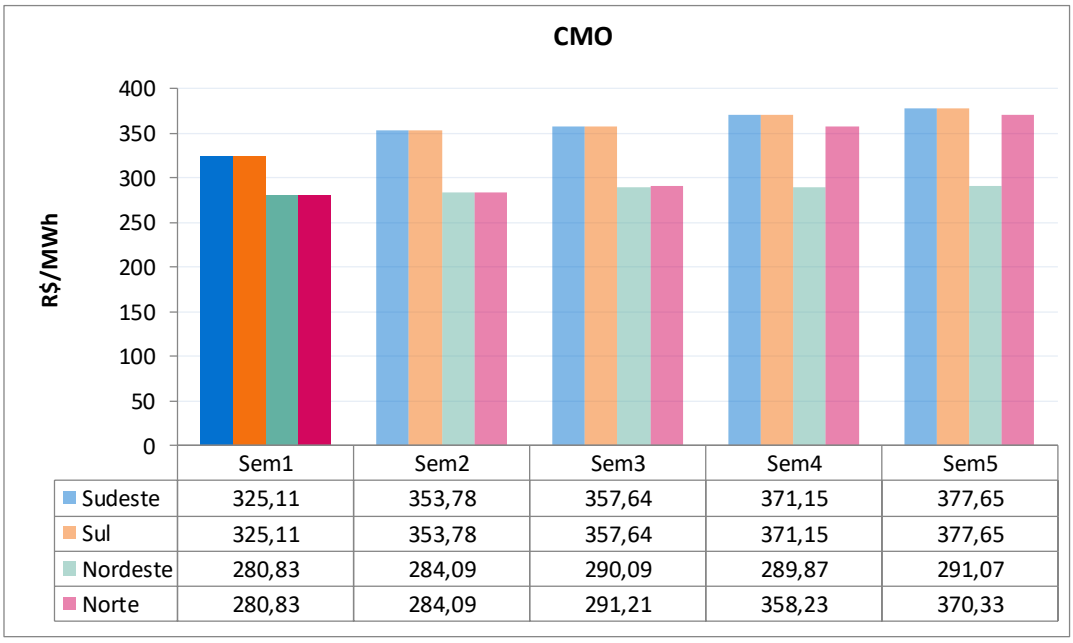

	Sem1	Sem2	Sem3	Sem4	Sem5
Sudeste	325,11	353,78	357,64	371,15	377,65
Sul	325,11	353,78	357,64	371,15	377,65
Nordeste	280,83	284,09	290,09	289,87	291,07
Norte	280,83	284,09	291,21	358,23	370,33

6.2. POLÍTICA DE OPERAÇÃO ENERGÉTICA

Para esta semana operativa, está prevista a seguinte política de intercâmbio de energia entre regiões:

Região SE/CO → Geração minimizada de acordo com os condicionantes hidráulicos.

Região Sul → Geração dimensionada para fechamento do balanço energético do SIN.

Região NE → Aumento da geração eólica e possível exportação de energia, modulando em função de seus recursos energéticos, respeitando-se os limites elétricos vigentes.

Região Norte → Continuidade da exploração das disponibilidades energéticas, respeitando-se os limites elétricos vigentes.

O conteúdo desta publicação foi produzido pelo ONS com base em dados e informações de conhecimento público. É de responsabilidade exclusiva dos agentes e demais interessados a obtenção de outros dados e informações, a realização de análises, estudos e avaliações para fins de tomada de decisões, definição de estratégias de atuação, assunção de compromissos e obrigações e quaisquer outras finalidades, em qualquer tempo e sob qualquer condição. É proibida a reprodução ou utilização total ou parcial do presente sem a identificação da fonte.

7. GERAÇÃO TÉRMICA

A Figura 7 apresenta, para cada subsistema, o despacho térmico por modalidade indicado pelo DECOMP para a próxima semana operativa.

Figura 7 – Geração térmica para a próxima semana operativa

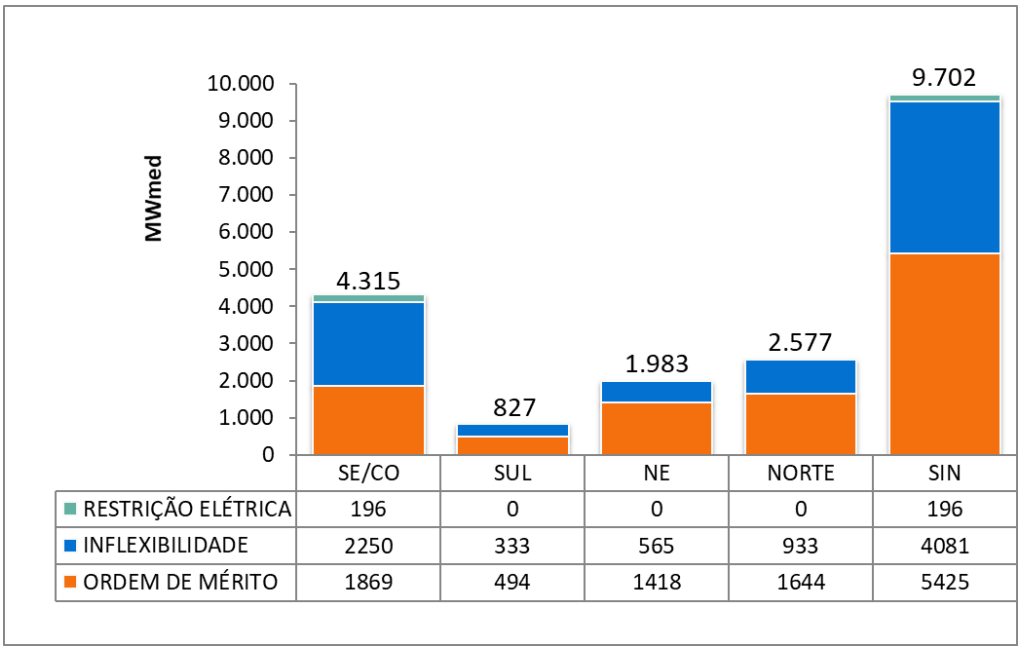

Na tabela abaixo segue a Indicação de despacho antecipado por ordem de mérito de custo para a semana de 31/07/2021 a 06/08/2021.

Tabela 5 – UTEs com contrato de combustível GNL

UTE			Benefício (R$/MWh)		
Nome	Cod	CVU (R$/MWh)	Carga Pesada	Carga Média	Carga Leve
SANTA CRUZ	86	204,96	1013,76 (1)	1013,76 (1)	1013,46 (1)
LUIZORMELO	15	312,25	1013,76 (1)	1013,76 (1)	1013,46 (1)
PSERGIPE I	224	301,28	286,84 (2)	286,84 (2)	286,82 (2)

(1) Comandado o despacho antecipado por ordem de mérito de custo nesse patamar

(2) NÃO foi comandado o despacho antecipado por ordem de mérito de custo nesse patamar

Assim sendo, há previsão de despacho antecipado por ordem de mérito de custo para as UTE Santa Cruz e Luiz O. R. Melo, para a semana de 31/07 a 06/08/2021.

Embora a UTE Porto Sergipe I não esteja despachada por ordem de mérito de custo, o ONS comanda seu despacho antecipado em sua totalidade, para a semana de 30/07 a 06/08/2021, por garantia energética.

O conteúdo desta publicação foi produzido pelo ONS com base em dados e informações de conhecimento público. É de responsabilidade exclusiva dos agentes e demais interessados a obtenção de outros dados e informações, a realização de análises, estudos e avaliações para fins de tomada de decisões, definição de estratégias de atuação, assunção de compromissos e obrigações e quaisquer outras finalidades, em qualquer tempo e sob qualquer condição. É proibida a reprodução ou utilização total ou parcial do presente sem a identificação da fonte.

8. IMPORTAÇÃO DE ENERGIA DA REPÚBLICA ORIENTAL DO URUGUAI

8.1. República Oriental do Uruguai

Para a semana operativa de 29/05/2021 a 04/06/2021, não foi declarada oferta de importação de energia da República Oriental do Uruguai para o Sistema Interligado Nacional - SIN através das conversoras de Rivera (70 MW) e Melo (500 MW).

8.2. República da Argentina

Para a semana operativa de 29/05/2021 a 04/06/2021, não foi declarada oferta de importação de energia da República da Argentina para o Sistema Interligado Nacional - SIN através das conversoras de Garabi I (1.100 MW) e Garabi II (1.100 MW).

Nota: Detalhes sobre a importação de energia vide Portaria Nº 339, de 15 de agosto de 2018 disponível em: http://pesquisa.in.gov.br/imprensa/jsp/visualiza/index.jsp?data=17/08/2018&jornal=515&pagina=60&totalArquivos=136

9. ESTIMATIVA DE ENCARGOS OPERATIVOS

A tabela a seguir apresenta a expectativa do custo de despacho térmico por restrição elétrica para esta semana operativa.

Tabela 6 – Expectativa de custo de despacho térmico por Restrição Elétrica

UTE Potência Instalada (MW)	CVU (R$/MWh)	Geração (MWmed)			ESS ELÉTRICO
		Carga Pesada	Carga Média	Carga Leve	
LUIZORMELO (204)	R$ 312,25	196,0	196,0	196,0	**R$ 72.269,12**
TOTAL SE/CO					**R$ 72.269,12**

O conteúdo desta publicação foi produzido pelo ONS com base em dados e informações de conhecimento público. É de responsabilidade exclusiva dos agentes e demais interessados a obtenção de outros dados e informações, a realização de análises, estudos e avaliações para fins de tomada de decisões, definição de estratégias de atuação, assunção de compromissos e obrigações e quaisquer outras finalidades, em qualquer tempo e sob qualquer condição. É proibida a reprodução ou utilização total ou parcial do presente sem a identificação da fonte.

11. ARMAZENAMENTOS OPERATIVOS

Para uma melhor avaliação de diversos cenários hidrometeorológicos, notadamente, aqueles de curto prazo e suas influências nas previsões de vazões nos subsistemas, os resultados deste PMO contemplam cenários de afluências visando melhor representar a ocorrência de precipitação e, consequentemente, seus efeitos sobre as afluências e armazenamentos.

Além dos resultados associados ao valor esperado das previsões de afluências, as simulações operativas também foram realizadas com os limites superior e inferior das previsões de afluências. Apresentamos a seguir os resultados obtidos com a aplicação dos diferentes cenários de afluência.

Tabela 7 – Previsão de ENA dos cenários de sensibilidade

Subsistema	ENERGIAS NATURAIS AFLUENTES					
	Previsão Mensal					
	LI		VE		LS	
	(MWmed)	%MLT	(MWmed)	%MLT	(MWmed)	%MLT
SE/CO	18.132	**56**	20.414	**63**	22.693	**70**
Sul	2.937	**28**	5.626	**54**	8.809	**84**
Nordeste	1.622	**35**	1.748	**38**	1.872	**41**
Norte	7.381	**69**	8.199	**77**	9.016	**84**

Tabela 8 – Previsão de %EARmáx para o final do mês

Subsistema	% EARmáx 28/05	% EARmáx - 30/06		
	NÍVEL INICIAL	NÍVEL PMO		
	VE	LI	VE	LS
SE/CO	32,1	27,7	28,9	29,9
Sul	55,6	59,2	69,8	78,4
Nordeste	63,9	53,1	54,2	55,8
Norte	84,5	81,5	83,3	84,2

O conteúdo desta publicação foi produzido pelo ONS com base em dados e informações de conhecimento público. É de responsabilidade exclusiva dos agentes e demais interessados a obtenção de outros dados e informações, a realização de análises, estudos e avaliações para fins de tomada de decisões, definição de estratégias de atuação, assunção de compromissos e obrigações e quaisquer outras finalidades, em qualquer tempo e sob qualquer condição. É proibida a reprodução ou utilização total ou parcial do presente sem a identificação da fonte.

12. RESERVATÓRIOS EQUIVALENTES DE ENERGIA

A seguir são apresentadas as previsões de Energia Natural Afluente para a próxima semana operativa e para o mês de junho, bem como as previsões de Energia Armazenada nos Reservatórios Equivalentes de Energia – REE, deste PMO.

Tabela 9 – Previsão de ENA por REE

Valor Esperado das Energias Naturais Afluentes				
REE	Previsão Semanal		Previsão Mensal	
	29/05/2021 a 04/06/2021		jun-21	
	(MWmed)	%MLT	(MWmed)	%MLT
Sudeste	2.540	64	2.352	67
Madeira	6.670	92	5.531	91
Teles Pires	1.470	89	1.217	90
Itaipu	1.994	56	2.246	62
Paraná	7.849	47	7.546	49
Paranapanema	1.011	41	1.248	48
Sul	2.324	47	3.541	67
Iguaçu	1.001	21	2.086	40
Nordeste	2.034	36	1.748	38
Norte	3.756	58	2.815	64
Belo Monte	6.146	91	3.859	81
Manaus	2.245	140	1.854	125

Tabela 10 – Previsão de %EARmáx por REE

% Energia Armazenável Máxima		
REE	Previsão Semanal	Previsão Mensal
	04-jun	30-jun
	(%EARmáx)	(%EARmáx)
Sudeste	41,3	39,1
Madeira	97,3	100,0
Teles Pires	94,3	75,5
Itaipu	18,6	98,0
Paraná	27,0	23,3
Paranapanema	38,9	41,6
Sul	43,7	56,5
Iguaçu	68,8	81,8
Nordeste	62,7	54,2
Norte	85,0	82,4
Belo Monte	100,0	100,0
Manaus	90,6	100,0

O conteúdo desta publicação foi produzido pelo ONS com base em dados e informações de conhecimento público. É de responsabilidade exclusiva dos agentes e demais interessados a obtenção de outros dados e informações, a realização de análises, estudos e avaliações para fins de tomada de decisões, definição de estratégias de atuação, assunção de compromissos e obrigações e quaisquer outras finalidades, em qualquer tempo e sob qualquer condição. É proibida a reprodução ou utilização total ou parcial do presente sem a identificação da fonte.

13. DESPACHO TÉRMICO POR MODALIDADE, PATAMAR DE CARGA E USINA

Nas tabelas abaixo, a diferenciação entre geração por inflexibilidade e por ordem de mérito tem caráter informativo, com o objetivo de detalhar a informação de inflexibilidade enviada pelos respectivos agentes para o PMO. Ressalta-se que nas etapas de Programação Diária e Tempo Real, o montante despachado nas usinas termelétricas indicadas por ordem de mérito é plenamente intitulado como ordem de mérito.

REGIÃO SUDESTE/CENTRO-OESTE

Térmicas Potência (MW)	Combustível	CVU (R$/MWh)	Inflexibilidade			Ordem de Mérito			Total Mérito e INFL.			Razão Elétrica			Total UTE		
			P	M	L	P	M	L	P	M	L	P	M	L	P	M	L
ATLAN_CSA (255)	Resíduos	0,00	156,0	156,0	156,0				156,0	156,0	156,0				156,0	156,0	156,0
ANGRA 2 (1350)	Nuclear	20,12	1220,0	1220,0	1220,0	0,0	0,0	0,0	1220,0	1220,0	1220,0				1220,0	1220,0	1220,0
ANGRA 1 (640)	Nuclear	31,17	640,0	640,0	640,0	0,0	0,0	0,0	640,0	640,0	640,0				640,0	640,0	640,0
NORTEFLU 1 (400)	Gás	84,73				400,0	400,0	400,0	400,0	400,0	400,0				400,0	400,0	400,0
NORTEFLU 2 (100)	Gás	96,23				100,0	100,0	100,0	100,0	100,0	100,0				100,0	100,0	100,0
O.PINTADA (50)	Biomassa	112,47	5,0	5,0	5,0	45,0	45,0	45,0	50,0	50,0	50,0				50,0	50,0	50,0
UTE STA VI (41)	Biomassa	121,49	13,0	13,0	13,0	28,4	28,4	28,4	41,4	41,4	41,4				41,4	41,4	41,4
PREDILECTA (5)	Biomassa	158,95	5,0	5,0	5,0	0,0	0,0	0,0	5,0	5,0	5,0				5,0	5,0	5,0
NORTEFLU 3 (200)	Gás	183,63				200,0	200,0	200,0	200,0	200,0	200,0				200,0	200,0	200,0
ATLANTICO (235)	Resíduos	199,08	211,5	211,5	211,5	0,0	0,0	0,0	211,5	211,5	211,5				211,5	211,5	211,5
BAIXADA FL (530)	Gás	201,85				530,0	530,0	530,0	530,0	530,0	530,0				530,0	530,0	530,0
SANTA CRUZ (500)	GNL	204,96															
T.LAGOAS (350)	Gás	262,08				180,0	180,0	180,0	180,0	180,0	180,0				180,0	180,0	180,0
JUIZ DE FO (87)	Gás	283,74				84,8	84,8	84,8	84,8	84,8	84,8				84,8	84,8	84,8
ST.CRUZ 34 (436)	Óleo	310,41															
LUIZORMELO (204)	GNL	312,25										196,0	196,0	196,0	196,0	196,0	196,0
TERMORIO (1036)	Gás	328,83				510,0	500,3		510,0	500,3					510,0	500,3	0,0
CUBATAO (216)	Gás	345,29				209,0			209,0						209,0	0,0	0,0
SEROPEDICA (386)	Gás	409,94															
PIRAT.12 O (200)	Gás	470,34															
IBIRITE (226)	Gás	482,95															
NPIRATINGA (572)	Gás	548,04															
NORTEFLU 4 (127)	Gás	595,49															
CUIABA CC (529)	Gás	675,63															
T.MACAE (929)	Gás	737,31															
PALMEIR_GO (176)	Diesel	762,23															
TNORTE 2 (340)	Óleo	910,86															
VIANA (175)	Óleo	946,60															
CAMPOS (25)	Gás	978,10															
DAIA (44)	Diesel	1018,60															
GOIANIA 2 (140)	Diesel	1065,35															
XAVANTES (54)	Diesel	1463,86															
TOTAL SE/CO (10558)			2250,5	2250,5	2250,5	2287,2	2068,5	1568,2	4537,7	4319,0	3818,7	196,0	196,0	196,0	4733,7	4515,0	4170,7

REGIÃO SUL

Térmicas Potência (MW)	Combustível	CVU (R$/MWh)	Inflexibilidade			Ordem de Mérito			Total Mérito e INFL.			Razão Elétrica			Total UTE		
			P	M	L	P	M	L	P	M	L	P	M	L	P	M	L
URUGUAIANA (640)	Gás	0,00															
PAMPA SUL (345)	Carvão	69,75				0,0	0,0	0,0	0,0	0,0	0,0				0,0	0,0	0,0
SAO SEPE (8)	Biomassa	87,75	6,0	6,0	6,0	0,0	0,0	0,0	6,0	6,0	6,0				6,0	6,0	6,0
CANDIOTA_3 (350)	Carvão	89,47	325,0	325,0	325,0	0,0	0,0	0,0	325,0	325,0	325,0				325,0	325,0	325,0
J.LACER. C (363)	Carvão	206,84				0,0	0,0	0,0	0,0	0,0	0,0				0,0	0,0	0,0
J.LACER. B (262)	Carvão	244,14				262,0	262,0	262,0	262,0	262,0	262,0				262,0	262,0	262,0
J.LAC. A2 (132)	Carvão	245,21				132,0	132,0	132,0	132,0	132,0	132,0				132,0	132,0	132,0
J.LAC. A1 (100)	Carvão	270,48				100,0	100,0	100,0	100,0	100,0	100,0				100,0	100,0	100,0
MADEIRA (4)	Biomassa	320,44	2,0	2,0	2,0	1,0	1,0		3,0	3,0	2,0				3,0	3,0	2,0
FIGUEIRA (20)	Carvão	475,68															
CANOAS (249)	Diesel	698,14															
ARAUCARIA (484)	Gás	934,91															
TOTAL SUL (2957)			333,0	333,0	333,0	495,0	495,0	494,0	828,0	828,0	827,0	0,0	0,0	0,0	828,0	828,0	827,0

O conteúdo desta publicação foi produzido pelo ONS com base em dados e informações de conhecimento público. É de responsabilidade exclusiva dos agentes e demais interessados a obtenção de outros dados e informações, a realização de análises, estudos e avaliações para fins de tomada de decisões, definição de estratégias de atuação, assunção de compromissos e obrigações e quaisquer outras finalidades, em qualquer tempo e sob qualquer condição. É proibida a reprodução ou utilização total ou parcial do presente sem a identificação da fonte.

REGIÃO NORDESTE

Térmicas Potência (MW)	Combustível	CVU (R$/MWh)	Inflexibilidade			Ordem de Mérito			Total Mérito e INFL.			Razão Elétrica			Total UTE		
			P	M	L	P	M	L	P	M	L	P	M	L	P	M	L
ALTOS (13)	Diesel	0,00															
ARACATI (11)	Diesel	0,00															
BATURITE (11)	Diesel	0,00															
C.MAIOR (13)	Diesel	0,00															
CAUCAIA (15)	Diesel	0,00															
CRATO (13)	Diesel	0,00															
IGUATU (15)	Diesel	0,00															
JUAZEIRO N (15)	Diesel	0,00															
MARAMBAIA (13)	Diesel	0,00															
NAZARIA (13)	Diesel	0,00															
PECEM (15)	Diesel	0,00															
ERB CANDEI (17)	Biomassa	87,81	4,5	4,5	4,5	6,5	6,5	6,5	11,0	11,0	11,0				11,0	11,0	11,0
PROSPERIDA (28)	Gás	165,61	28,0	28,0	28,0	0,0	0,0	0,0	28,0	28,0	28,0				28,0	28,0	28,0
TERMOPE (533)	Gás	190,32	532,7	532,7	532,7	0,0	0,0	0,0	532,7	532,7	532,7				532,7	532,7	532,7
P.PECEM1 (720)	Carvão	233,97				720,0	720,0	720,0	720,0	720,0	720,0				720,0	720,0	720,0
P.PECEM2 (365)	Carvão	241,56				365,0	365,0	365,0	365,0	365,0	365,0				365,0	365,0	365,0
FORTALEZA (327)	Gás	245,46				326,6	326,6	326,6	326,6	326,6	326,6				326,6	326,6	326,6
PSERGIPE I (1516)	GNL	301,28															
TERMOCEARA (223)	Gás	430,00															
SYKUE I (30)	Biomassa	510,12															
VALE ACU (368)	Gás	526,79															
T.BAHIA (186)	Gás	537,33															
PERNAMBU_3 (201)	Óleo	816,54															
BAHIA_1 (31)	Óleo	817,22															
MARACANAU (168)	Óleo	920,98															
TERMOCABO (50)	Óleo	934,98															
TERMONE (171)	Óleo	938,29															
TERMOPB (171)	Óleo	938,29															
CAMPINA_GR (169)	Óleo	946,62															
SUAPE II (381)	Óleo	968,43															
POTIGUAR_3 (66)	Diesel	1002,31															
POTIGUAR (53)	Diesel	1002,32															
AREMBEPE (150)	Óleo	1021,02															
MURICY (147)	Óleo	1021,02															
GLOBAL I (149)	Óleo	1072,45															
GLOBAL II (149)	Óleo	1072,45															
PETROLINA (136)	Óleo	1120,20															
PAU FERRO (94)	Diesel	1134,71															
TERMOMANAU (143)	Diesel	1134,71															
TOTAL NE (6889)			565,2	565,2	565,2	1418,1	1418,1	1418,1	1983,3	1983,3	1983,3	0,0	0,0	0,0	1983,3	1983,3	1983,3

REGIÃO NORTE

Térmicas Potência (MW)	Combustível	CVU (R$/MWh)	Inflexibilidade			Ordem de Mérito			Total Mérito e INFL.			Razão Elétrica			Total UTE		
			P	M	L	P	M	L	P	M	L	P	M	L	P	M	L
C. ROCHA (85)	Gás	0,00	65,0	65,0	65,0				65,0	65,0	65,0				65,0	65,0	65,0
JARAQUI (75)	Gás	0,00	63,0	63,0	63,0				63,0	63,0	63,0				63,0	63,0	63,0
MANAUARA (67)	Gás	0,00	64,5	64,5	54,4				64,5	64,5	54,4				64,5	64,5	54,4
PONTA NEGR (66)	Gás	0,00	64,0	64,0	64,0				64,0	64,0	64,0				64,0	64,0	64,0
TAMBAQUI (93)	Gás	0,00	63,0	63,0	63,0				63,0	63,0	63,0				63,0	63,0	63,0
MARANHAO3 (519)	Gás	85,72	367,5	290,9	228,3	127,3	222,5	282,6	494,8	513,4	510,9				494,8	513,4	510,9
APARECIDA (166)	Gás	98,28	75,0	75,0	75,0	83,6	71,3	60,2	158,6	146,3	135,2				158,6	146,3	135,2
UTE MAUA 3 (591)	Gás	98,28	264,0	264,0	264,0	93,5	107,1	123,2	357,5	371,1	387,2				357,5	371,1	387,2
PARNAIB_IV (56)	Gás	151,69				37,5	37,5	37,5	37,5	37,5	37,5				37,5	37,5	37,5
MARAN_VL_7 (336)	Gás	189,11				326,0	334,1	333,0	326,0	334,1	333,0				326,0	334,1	333,0
MARAN_VL22 (1)	Gás	189,11				1,1	1,1	1,1	1,1	1,1	1,1				1,1	1,1	1,1
MARANIVL_7 (336)	Gás	189,11				325,9	334,1	333,0	325,9	334,1	333,0				325,9	334,1	333,0
MARANIVL22 (1)	Gás	189,11				1,1	1,1	1,1	1,1	1,1	1,1				1,1	1,1	1,1
N.VEN2_L22 (27)	Gás	232,01				27,0	27,0	27,0	27,0	27,0	27,0				27,0	27,0	27,0
N.VEN2_L7 (151)	Gás	232,27				144,4	149,7	149,0	144,4	149,7	149,0				144,4	149,7	149,0
P. ITAQUI (360)	Carvão	235,54				360,1	360,1	360,1	360,1	360,1	360,1				360,1	360,1	360,1
GERAMAR1 (166)	Óleo	946,58															
GERAMAR2 (166)	Óleo	946,58															
TOTAL NORTE (3264)			1026,0	949,4	876,7	1527,5	1645,6	1707,8	2553,5	2595,0	2584,5	0,0	0,0	0,0	2553,5	2595,0	2584,5

O conteúdo desta publicação foi produzido pelo ONS com base em dados e informações de conhecimento público. É de responsabilidade exclusiva dos agentes e demais interessados a obtenção de outros dados e informações, a realização de análises, estudos e avaliações para fins de tomada de decisões, definição de estratégias de atuação, assunção de compromissos e obrigações e quaisquer outras finalidades, em qualquer tempo e sob qualquer condição. É proibida a reprodução ou utilização total ou parcial do presente sem a identificação da fonte.