1. APRESENTAÇÃO

No início da semana de 29/05 a 04/06/2021 o avanço de uma frente fria pelas regiões Sul e Sudeste/Centro-Oeste ocasionou totais elevados de precipitação na bacia do rio Jacuí, na cascata do Uruguai, no Paranapanema e na calha principal do Paraná.

Na semana de 05/06 a 11/06/2021 uma nova frente fria avança pelas regiões Sul e Sudeste/Centro-Oeste ocasionando chuva fraca à moderada nas bacias dos rios Jacuí, Uruguai e precipitação de intensidade fraca no Iguaçu. Após a passagem da frente fria, a atuação de áreas de instabilidade ocasiona chuva fraca nas bacias dos rios Uruguai, Iguaçu, na incremental a UHE Itaipu e em pontos isolados do Paranapanema.

Para a semana operativa de 05/06 a 11/06/2021, houve oferta de energia da República Oriental do Uruguai e da República da Argentina. De acordo com o Art. 2º da Portaria MME nº 339, de 15 de agosto de 2018, as ofertas para importação de energia não foram consideradas na elaboração do PMO. Para a referida semana, não houve oferta de energia da República da Argentina.

Os valores médios semanais do Custo Marginal de Operação – CMO dos subsistemas do SIN sofreram as seguintes alterações em relação à semana anterior:

- SE/CO: de R$ 325,11/MWh para R$ 431,24/MWh
- Sul: de R$ 325,11/MWh para R$ 431,24/MWh
- Nordeste: de R$ 280,83/MWh para R$ 303,90/MWh
- Norte: de R$ 280,83/MWh para R$ 350,26/MWh

Desde o dia 01/01/2020, o despacho por ordem de mérito é indicado diariamente pelos resultados do modelo DESSEM. Assim, o despacho por ordem de mérito semanal, conforme publicado nesse documento, tem caráter apenas informativo. Da mesma forma, desde o dia 01/01/2021, a formação de preço deixou o formato semanal/patamar de carga e passou a ser horário, de acordo também com os resultados do modelo DESSEM.

2. NOTÍCIAS

Nos dias 24 e 25 de junho será realizada a reunião de elaboração do PMO Julho de 2021, com transmissão ao vivo através do site do ONS.

Como medida adicional de prevenção ao Coronavírus, o ONS informa que está suspensa, temporariamente, a participação presencial nas reuniões.

3. ANÁLISE DAS CONDIÇÕES HIDROMETEOROLÓGICAS

3.1. PREVISÃO PARA A PRÓXIMA SEMANA

No início da próxima semana operativa uma nova frente fria avança rapidamente pelas regiões Sul e Sudeste/Centro-Oeste ocasionando chuva fraca à moderada nas bacias dos rios Jacuí, Uruguai e

O conteúdo desta publicação foi produzido pelo ONS com base em dados e informações de conhecimento público. É de responsabilidade exclusiva dos agentes e demais interessados a obtenção de outros dados e informações, a realização de análises, estudos e avaliações para fins de tomada de decisões, definição de estratégias de atuação, assunção de compromissos e obrigações e quaisquer outras finalidades, em qualquer tempo e sob qualquer condição. É proibida a reprodução ou utilização total ou parcial do presente sem a identificação da fonte.

precipitação de intensidade fraca no Iguaçu (**Figura 1**). Após a passagem da frente fria, a atuação de áreas de instabilidade ocasiona chuva fraca nas bacias dos rios Uruguai, Iguaçu, na incremental a UHE Itaipu e em pontos isolados do Paranapanema.

Figura 1- Precipitação acumulada prevista pelo modelo ECMWF (ECMWF) para o período de 05/06/2021 a 11/06/2021.

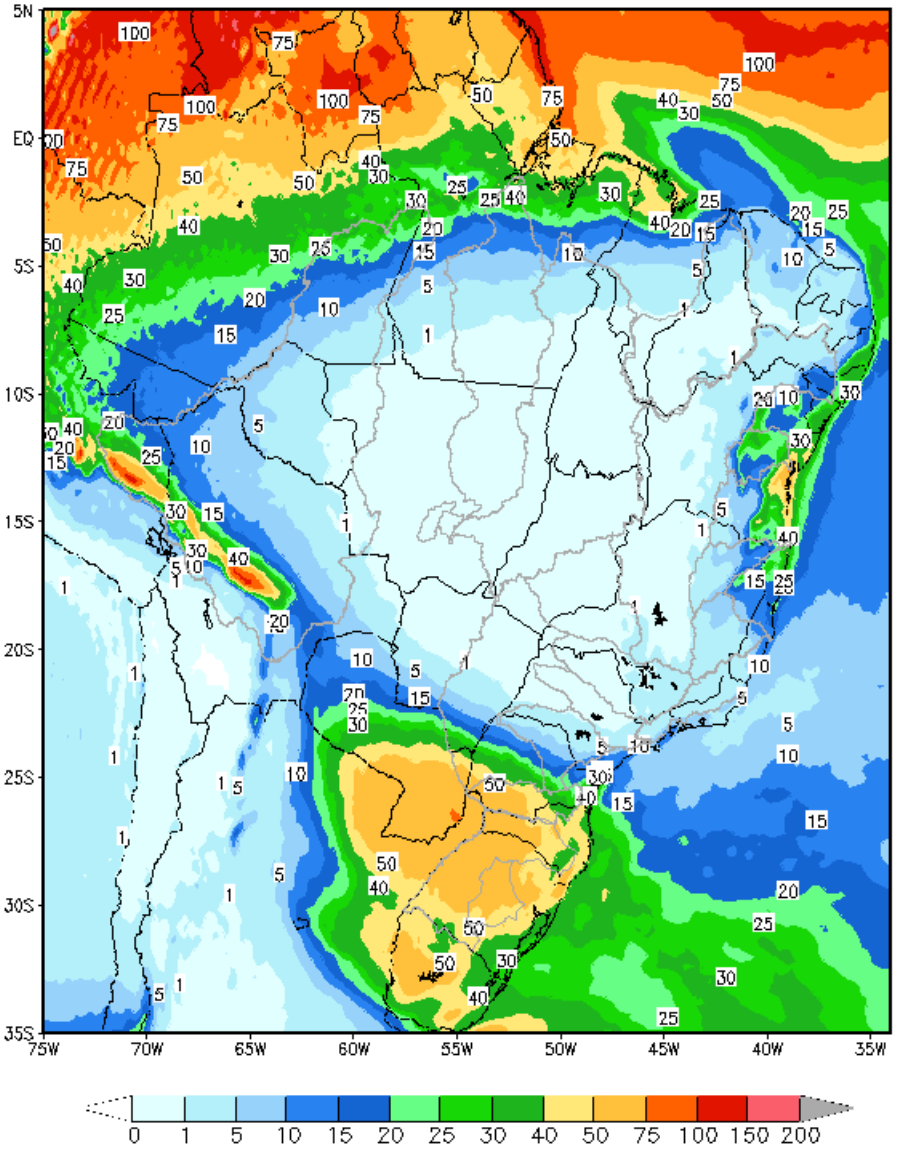

Em comparação com os valores estimados para a semana em curso, prevê-se para a próxima semana operativa recessão nas afluências de todos os subsistemas. A previsão mensal para junho indica a ocorrência de afluências abaixo da média histórica para todos os subsistemas.

Tabela 1 – Previsão de ENAs da Revisão 1 de Junho/2021

Revisão 1 do PMO de Junho/2021 - ENAs previstas				
Subsistema	05/06 a 11/06/2021		Mês de junho	
	MWmed	%MLT	MWmed	%MLT
SE/CO	20.941	64	20.385	62
S	3.608	34	5.135	49
NE	1.830	40	1.783	39
N	9.024	84	7.938	74

O conteúdo desta publicação foi produzido pelo ONS com base em dados e informações de conhecimento público. É de responsabilidade exclusiva dos agentes e demais interessados a obtenção de outros dados e informações, a realização de análises, estudos e avaliações para fins de tomada de decisões, definição de estratégias de atuação, assunção de compromissos e obrigações e quaisquer outras finalidades, em qualquer tempo e sob qualquer condição. É proibida a reprodução ou utilização total ou parcial do presente sem a identificação da fonte.

4. PREVISÃO DE CARGA

Para o mês de junho/21 as previsões de carga consolidadas levaram em consideração a melhorias das expectativas para o próximo semestre. Segundo a FGV - Fundação Getúlio Vargas, o avanço da vacinação, ainda que em ritmo lento, e a ampliação das exportações devido à maior demanda externa são fatores que estão contribuindo para a melhora dessas expectativas.

As previsões meteorológicas indicam para a próxima semana operativa, temperaturas semelhantes às observadas na semana em curso para todas as regiões do Brasil, com os seguintes destaques:

- ✓ Regiões SE/CO e Sul: Expectativa de ocorrência de temperaturas mais amenas em parte da próxima semana operativa, quando comparadas as registradas na semana em curso.
- ✓ Região Nordeste: Ocorrência de totais de precipitação inferiores aos observados nas últimas semanas.
- ✓ Região Norte: Expectativa de elevados totais de precipitação, principalmente em Manaus e Belém.

As taxas de crescimento previstas para o mês de junho em relação ao mesmo mês do ano anterior, são de 7,1% para os subsistemas Sudeste/Centro-Oeste, 5,6% para o subsistema Sul, 9,9% no Nordeste e 12,5% no subsistema do Norte.

Tabela 2 – Evolução da carga do PMO de Junho 2021

Subsistema	CARGA SEMANAL (MWmed)					CARGA MENSAL (MWmed)	
	1ª Sem	2ª Sem	3ª Sem	4ª Sem	5ª Sem	jun/21	Var. (%) jun/21 -> jun/20
SE/CO	38.774	38.735	38.472	38.018	37.469	38.301	7,1%
Sul	10.681	11.371	11.404	11.413	11.423	11.305	5,6%
Nordeste	10.947	11.109	10.971	10.618	10.443	10.830	9,9%
Norte	6.053	6.149	6.090	5.975	5.949	6.049	12,5%
SIN	**66.455**	**67.364**	**66.937**	**66.024**	**65.284**	**66.485**	**7,7%**

O conteúdo desta publicação foi produzido pelo ONS com base em dados e informações de conhecimento público. É de responsabilidade exclusiva dos agentes e demais interessados a obtenção de outros dados e informações, a realização de análises, estudos e avaliações para fins de tomada de decisões, definição de estratégias de atuação, assunção de compromissos e obrigações e quaisquer outras finalidades, em qualquer tempo e sob qualquer condição. É proibida a reprodução ou utilização total ou parcial do presente sem a identificação da fonte.

5. PRINCIPAIS RESULTADOS

5.1. CUSTO MARGINAL DE OPERAÇÃO (CMO)

A tabela a seguir apresenta o CMO, por subsistema e patamar de carga para próxima semana operativa.

Tabela 3 – CMO por patamar de carga

Patamares de Carga	CMO (R$/MWh)			
	SE/CO	S	NE	N
Pesada	458,54	458,54	306,92	350,26
Média	455,05	455,05	304,72	350,26
Leve	398,92	398,92	301,12	350,26
Média Semanal	431,24	431,24	303,90	350,26

Na figura a seguir é apresentada a evolução do CMO médio semanal ao longo deste PMO.

Figura 2 – Evolução semanal do CMO

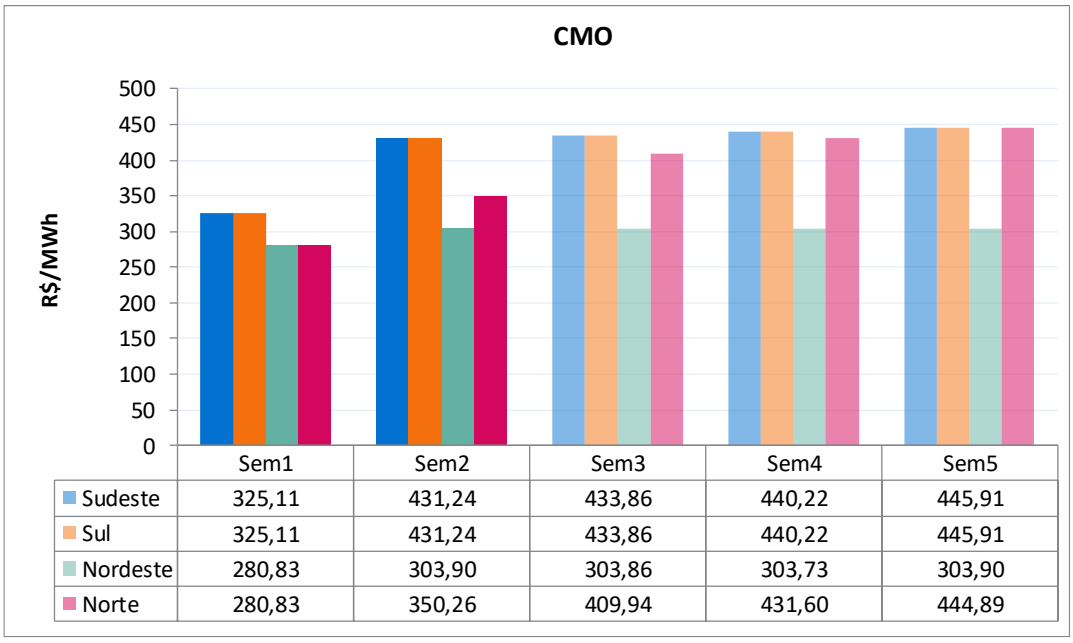

5.2. POLÍTICA DE OPERAÇÃO ENERGÉTICA

Para esta semana operativa, está prevista a seguinte política de intercâmbio de energia entre regiões:

Região SE/CO → Geração minimizada de acordo com os condicionantes hidráulicos.

Região Sul → Geração dimensionada para fechamento do balanço energético do SIN.

Região NE → Aumento da geração eólica e possível exportação de energia, modulando em função de seus recursos energéticos, respeitando-se os limites elétricos vigentes.

Região Norte → Continuidade da exploração das disponibilidades energéticas, respeitando-se os limites elétricos vigentes.

O conteúdo desta publicação foi produzido pelo ONS com base em dados e informações de conhecimento público. É de responsabilidade exclusiva dos agentes e demais interessados a obtenção de outros dados e informações, a realização de análises, estudos e avaliações para fins de tomada de decisões, definição de estratégias de atuação, assunção de compromissos e obrigações e quaisquer outras finalidades, em qualquer tempo e sob qualquer condição. É proibida a reprodução ou utilização total ou parcial do presente sem a identificação da fonte.

6. ANÁLISE DA VARIAÇÃO SEMANAL DO CMO

Esta análise visa identificar os principais parâmetros cujas atualizações impactaram os CMO deste PMO, em comparação com os valores obtidos na última revisão.

Foram realizados 8 estudos, onde o caso inicial foi construído com base nos dados oficiais da última revisão deste PMO. Neste primeiro estudo, denominado de "previsão perfeita", a partida dos reservatórios foi estimada conforme indicado para esta semana na última revisão.

O segundo estudo foi realizado com os dados do caso inicial sendo substituída a previsão de vazões.

A partir do conjunto de dados do segundo estudo foram elaborados os demais casos onde foram atualizadas, sequencialmente, as seguintes informações: níveis de partida dos reservatórios, previsão de carga, disponibilidade das usinas térmicas e hidráulicas, restrições de limites de intercâmbio, restrições hidráulicas e, por fim, os demais dados que compõem toda informação referente a atual revisão.

Os custos marginais de operação dos subsistemas Sudeste/Centro-Oeste e Sul estão acoplados e são apresentados na Figura 3. Para os estes subsistemas, como pode ser observado no resultado do estudo denominado "previsão perfeita", já era prevista a elevação significativa do CMO. Outros fatores que influenciaram na elevação do CMO dos subsistemas SE/CO e S foram a atualização dos níveis de partida dos reservatórios e da previsão de carga.

Os custos marginais de operação dos subsistemas Nordeste e Norte não estão acoplados e a variação do CMO pode ser vista nas Figura 4 e Figura 5, respectivamente.

O principal fator que influenciou no aumento do CMO em relação à semana anterior no subsistema Nordeste foi a atualização da previsão de vazões. Para o subsistema Norte, o fator mais relevante para a variação do CMO foi a atualização das disponibilidades das usinas, seguido da atualização das vazões.

Figura 3 – Análise da variação do CMO nos subsistemas SE/CO

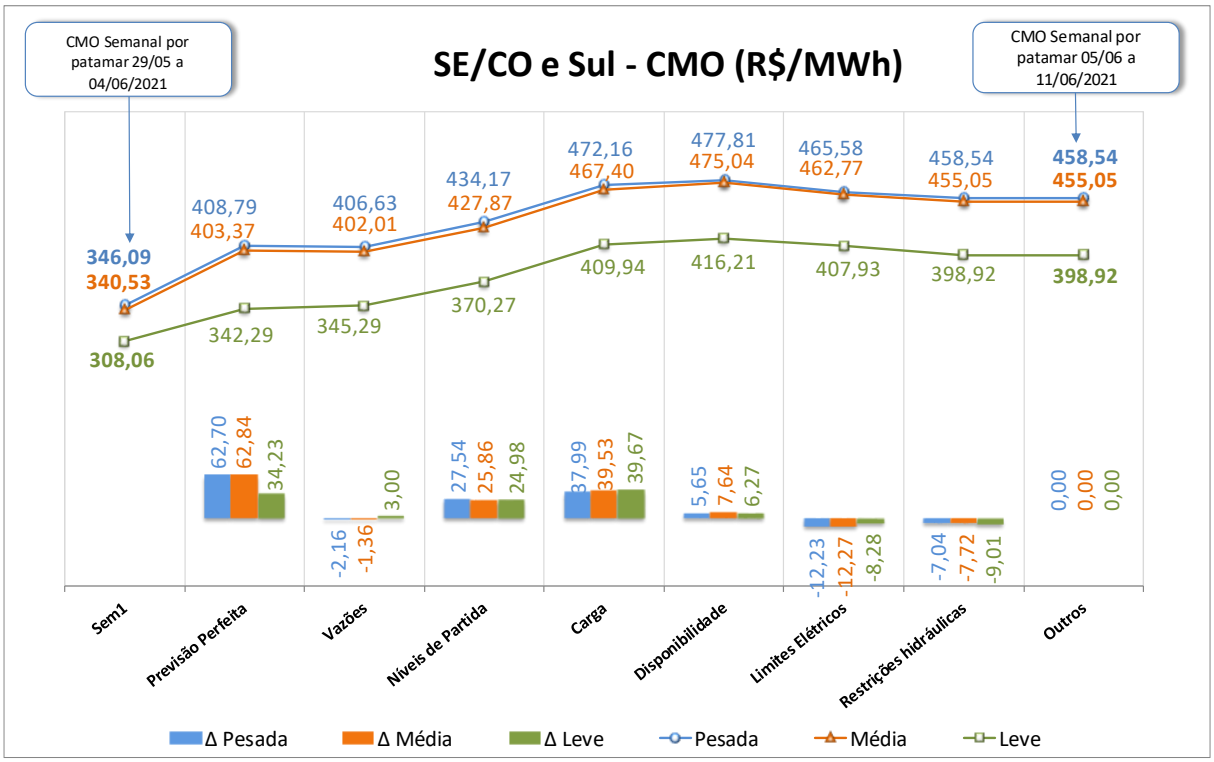

O conteúdo desta publicação foi produzido pelo ONS com base em dados e informações de conhecimento público. É de responsabilidade exclusiva dos agentes e demais interessados a obtenção de outros dados e informações, a realização de análises, estudos e avaliações para fins de tomada de decisões, definição de estratégias de atuação, assunção de compromissos e obrigações e quaisquer outras finalidades, em qualquer tempo e sob qualquer condição. É proibida a reprodução ou utilização total ou parcial do presente sem a identificação da fonte.

Figura 4 – Análise da variação do CMO nos subsistemas Nordeste

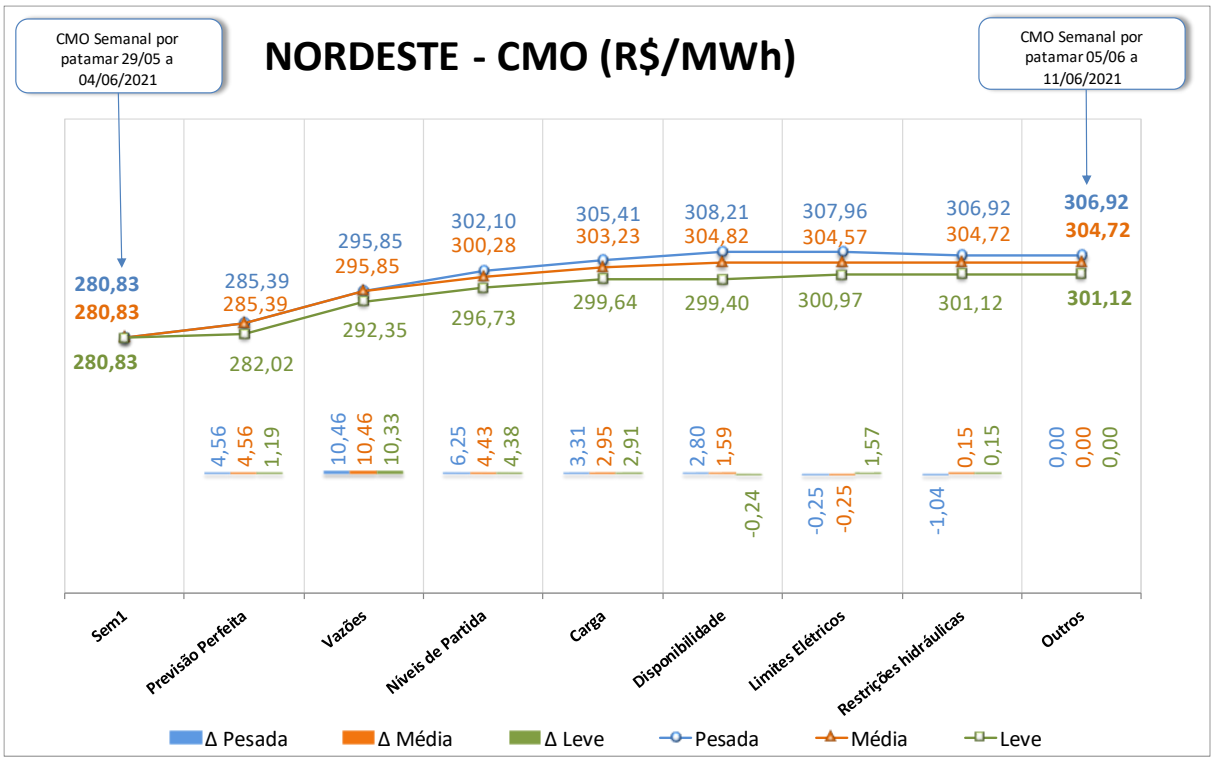

Figura 5 – Análise da variação do CMO nos subsistemas Norte

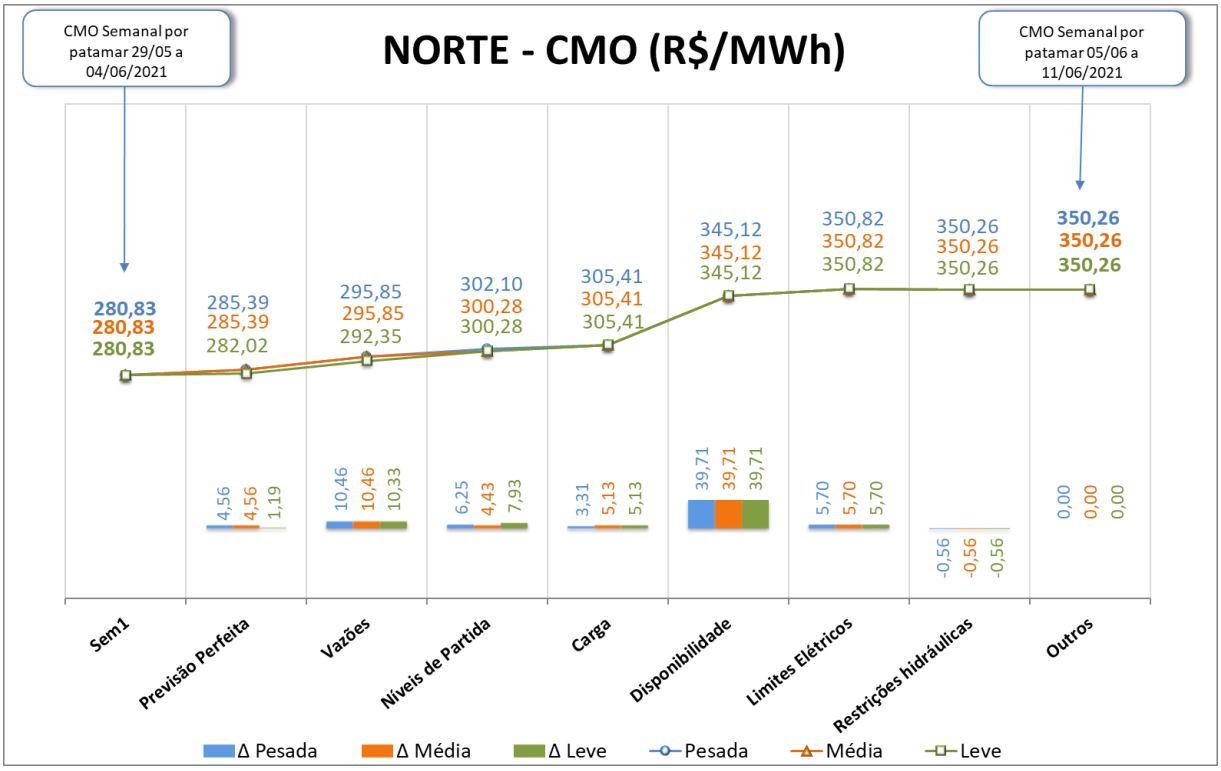

O conteúdo desta publicação foi produzido pelo ONS com base em dados e informações de conhecimento público. É de responsabilidade exclusiva dos agentes e demais interessados a obtenção de outros dados e informações, a realização de análises, estudos e avaliações para fins de tomada de decisões, definição de estratégias de atuação, assunção de compromissos e obrigações e quaisquer outras finalidades, em qualquer tempo e sob qualquer condição. É proibida a reprodução ou utilização total ou parcial do presente sem a identificação da fonte.

7. GERAÇÃO TÉRMICA

A Figura 6 apresenta, para cada subsistema, o despacho térmico por modalidade indicado pelo DECOMP para a próxima semana operativa.

Figura 6 – Geração térmica para a próxima semana operativa

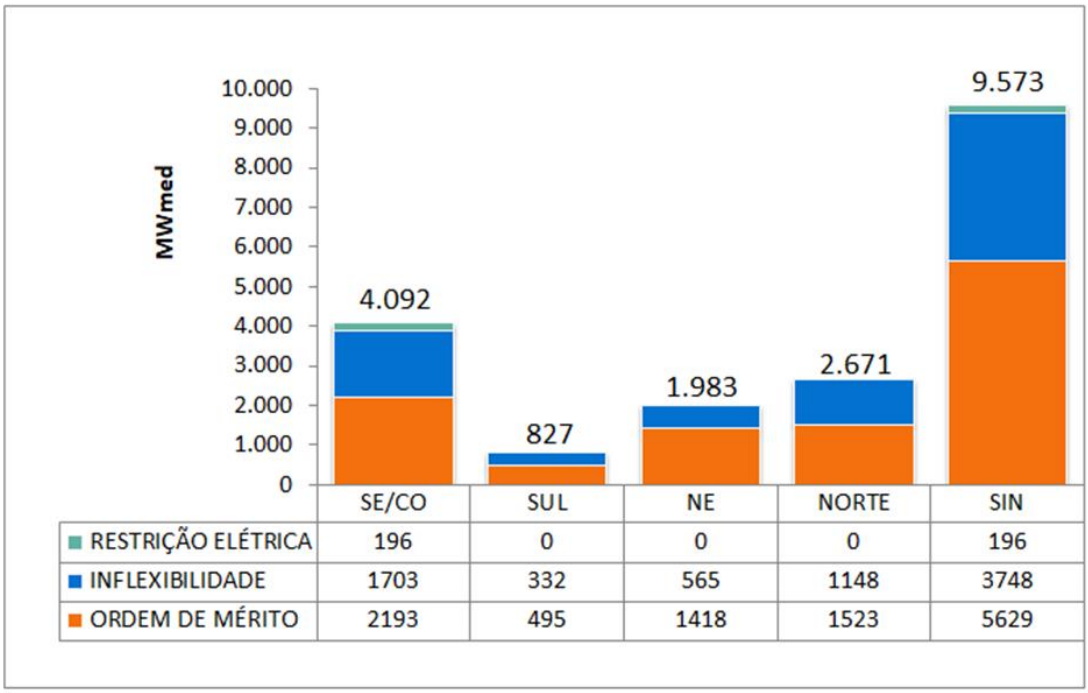

Na tabela abaixo segue a Indicação de despacho antecipado por ordem de mérito de custo para a semana de 07/08 a 13/08/2021.

Tabela 4 – UTEs com contrato de combustível GNL

UTE			Benefício (R$/MWh)		
Nome	Cod	CVU (R$/MWh)	Carga Pesada	Carga Média	Carga Leve
SANTA CRUZ	86	204,96	1080,40 (1)	1080,40 (1)	1080,03 (1)
LUIZORMELO	15	312,25	1080,40 (1)	1080,40 (1)	1080,03 (1)
PSERGIPE I	224	301,28	298,50 (2)	298,50 (2)	298,49 (2)

(1) Comandado o despacho antecipado por ordem de mérito de custo nesse patamar

(2) NÃO foi comandado o despacho antecipado por ordem de mérito de custo nesse patamar

Assim sendo, há previsão de despacho antecipado por ordem de mérito de custo para as UTE Santa Cruz e Luiz O. R. Melo, para a semana de 07/08 a 13/08/2021.

Embora a UTE Porto Sergipe I não esteja despachada por ordem de mérito de custo, o ONS comanda seu despacho antecipado em sua totalidade, para a semana de 07/08 a 13/08/2021, por garantia energética.

O conteúdo desta publicação foi produzido pelo ONS com base em dados e informações de conhecimento público. É de responsabilidade exclusiva dos agentes e demais interessados a obtenção de outros dados e informações, a realização de análises, estudos e avaliações para fins de tomada de decisões, definição de estratégias de atuação, assunção de compromissos e obrigações e quaisquer outras finalidades, em qualquer tempo e sob qualquer condição. É proibida a reprodução ou utilização total ou parcial do presente sem a identificação da fonte.

8. IMPORTAÇÃO DE ENERGIA DA REPÚBLICA ORIENTAL DO URUGUAI

8.1. República Oriental do Uruguai

Para a próxima semana operativa, foram declaradas as seguintes ofertas de importação de energia da República Oriental do Uruguai para o Sistema Interligado Nacional - SIN através das conversoras de Rivera (70 MW) e Melo (500 MW).

- **Eletrobras**

Tabela 5 – Energia ofertada para importação

	Oferta de Energia para a Semana de 05/06 a 11/06 (MWmed)			
	Bloco 1	Bloco 2	Bloco 3	Total
Carga Pesada	70	90	135	295
Carga Média	70	90	135	295
Carga Leve	70	90	135	295
CVU (R$/MWh)	642,27	739,42	945,81	

- **Enel**

Conforme declaração do agente, esta importação poderá ser realizada exclusivamente pela conversora Melo.

Tabela 6 – Energia ofertada para importação

	Oferta de Energia para a Semana de 05/06 a 11/06 (MWmed)			
	Bloco 1	Bloco 2	Bloco 3	Total
Carga Pesada	50	90	135	275
Carga Média	50	90	135	275
Carga Leve	50	90	135	275
CVU (R$/MWh)	647,06	743,65	953,06	

O conteúdo desta publicação foi produzido pelo ONS com base em dados e informações de conhecimento público. É de responsabilidade exclusiva dos agentes e demais interessados a obtenção de outros dados e informações, a realização de análises, estudos e avaliações para fins de tomada de decisões, definição de estratégias de atuação, assunção de compromissos e obrigações e quaisquer outras finalidades, em qualquer tempo e sob qualquer condição. É proibida a reprodução ou utilização total ou parcial do presente sem a identificação da fonte.

8.2. República da Argentina

- **Enel**

Para a próxima semana operativa, foi declarada a seguinte oferta de importação de energia da República da Argentina para o SIN através das conversoras de Garabi 1 (1.100 MW) e Garabi 2 (1.100 MW).

Tabela 7 – Energia ofertada para importação

	Oferta de Energia para a Semana de 05/06 a 11/06 (MWmed)		
	Bloco 1	Bloco 2	Total
Carga Pesada	300	400	700
Carga Média	300	400	700
Carga Leve	300	400	700
CVU (R$/MWh)	742,80	1.061,05	

Nota: Detalhes sobre a importação de energia vide Portaria Nº 339, de 15 de agosto de 2018 disponível em: http://pesquisa.in.gov.br/imprensa/jsp/visualiza/index.jsp?data=17/08/2018&jornal=515&pagina=60&totalArquivos=136

O conteúdo desta publicação foi produzido pelo ONS com base em dados e informações de conhecimento público. É de responsabilidade exclusiva dos agentes e demais interessados a obtenção de outros dados e informações, a realização de análises, estudos e avaliações para fins de tomada de decisões, definição de estratégias de atuação, assunção de compromissos e obrigações e quaisquer outras finalidades, em qualquer tempo e sob qualquer condição. É proibida a reprodução ou utilização total ou parcial do presente sem a identificação da fonte.

9. ARMAZENAMENTOS OPERATIVOS

Para uma melhor avaliação de diversos cenários hidrometeorológicos, notadamente, aqueles de curto prazo e suas influências nas previsões de vazões nos subsistemas, os resultados desta Revisão do PMO contemplam cenários de afluências visando melhor representar a ocorrência de precipitação e, consequentemente, seus efeitos sobre as afluências e armazenamentos.

Além dos resultados associados ao valor esperado das previsões de afluências, as simulações operativas também foram realizadas com os limites superior e inferior das previsões de afluências. Apresentamos a seguir os resultados obtidos com a aplicação dos diferentes cenários de afluência.

Tabela 8 – Previsão de ENA dos cenários de sensibilidade

Subsistema	ENERGIAS NATURAIS AFLUENTES					
	Previsão Mensal					
	LI		VE		LS	
	(MWmed)	%MLT	(MWmed)	%MLT	(MWmed)	%MLT
SE/CO	18.489	**57**	20.385	**62**	22.277	**68**
Sul	2.860	**27**	5.135	**49**	7.571	**72**
Nordeste	1.507	**33**	1.783	**39**	2.059	**45**
Norte	7.274	**68**	7.938	**74**	8.601	**80**

Tabela 8 – Previsão de %EARmáx para o final do mês

Subsistema	% EARmáx 04/06	% EARmáx - 30/06		
	NÍVEL INICIAL	NÍVEL PMO		
	VE	LI	VE	LS
SE/CO	**31,8**	**27,9**	**28,9**	**29,6**
Sul	**57,6**	**58,6**	**66,5**	**74,3**
Nordeste	**62,7**	**53,0**	**53,5**	**54,3**
Norte	**84,6**	**79,1**	**81,5**	**83,3**

O conteúdo desta publicação foi produzido pelo ONS com base em dados e informações de conhecimento público. É de responsabilidade exclusiva dos agentes e demais interessados a obtenção de outros dados e informações, a realização de análises, estudos e avaliações para fins de tomada de decisões, definição de estratégias de atuação, assunção de compromissos e obrigações e quaisquer outras finalidades, em qualquer tempo e sob qualquer condição. É proibida a reprodução ou utilização total ou parcial do presente sem a identificação da fonte.

10. RESERVATÓRIOS EQUIVALENTES DE ENERGIA

A seguir são apresentadas as previsões de Energia Natural Afluente para a próxima semana operativa e para o mês de junho, bem como as previsões de Energia Armazenada nos Reservatórios Equivalentes de Energia – REE, desta Revisão do PMO.

Tabela 9 – Previsão de ENA por REE

Valor Esperado das Energias Naturais Afluentes				
REE	Previsão Semanal		Previsão Mensal	
	05/06/2021 a 11/06/2021		jun-21	
	(MWmed)	%MLT	(MWmed)	%MLT
Sudeste	2.370	67	2.279	65
Madeira	5.791	95	5.410	89
Teles Pires	1.287	95	1.169	86
Itaipu	2.157	59	2.250	62
Paraná	7.444	48	7.418	48
Paranapanema	1.603	62	1.590	61
Sul	2.803	53	3.755	71
Iguaçu	805	15	1.381	26
Nordeste	1.830	40	1.783	39
Norte	3.140	71	2.817	64
Belo Monte	4.203	88	3.455	72
Manaus	2.208	148	1.995	134

Tabela 10 – Previsão de %EARmáx por REE

% Energia Armazenável Máxima		
REE	Previsão Semanal	Previsão Mensal
	11-jun	30-jun
	(%EARmáx)	(%EARmáx)
Sudeste	40,8	39,2
Madeira	93,3	95,0
Teles Pires	83,2	74,0
Itaipu	25,1	94,4
Paraná	26,2	23,0
Paranapanema	42,0	45,1
Sul	48,6	59,7
Iguaçu	67,8	72,5
Nordeste	60,3	53,5
Norte	84,7	81,1
Belo Monte	100,0	100,0
Manaus	89,5	89,3

O conteúdo desta publicação foi produzido pelo ONS com base em dados e informações de conhecimento público. É de responsabilidade exclusiva dos agentes e demais interessados a obtenção de outros dados e informações, a realização de análises, estudos e avaliações para fins de tomada de decisões, definição de estratégias de atuação, assunção de compromissos e obrigações e quaisquer outras finalidades, em qualquer tempo e sob qualquer condição. É proibida a reprodução ou utilização total ou parcial do presente sem a identificação da fonte.

11. DESPACHO TÉRMICO POR MODALIDADE, PATAMAR DE CARGA E USINA

Nas tabelas abaixo, a diferenciação entre geração por inflexibilidade e por ordem de mérito tem caráter informativo, com o objetivo de detalhar a informação de inflexibilidade enviada pelos respectivos agentes para esta Revisão do PMO. Ressalta-se que nas etapas de Programação Diária e Tempo Real, o montante despachado nas usinas termelétricas indicadas por ordem de mérito é plenamente intitulado como ordem de mérito.

REGIÃO SUDESTE/CENTRO-OESTE																	
Térmicas Potência (MW)	Combustível	CVU (R$/MWh)	Inflexibilidade			Ordem de Mérito			Total Mérito e INFL.			Razão Elétrica			Total UTE		
			P	M	L	P	M	L	P	M	L	P	M	L	P	M	L
ATLAN_CSA (255)	Resíduos	0,00	162,0	162,0	162,0				162,0	162,0	162,0				162,0	162,0	162,0
ANGRA 2 (1350)	Nuclear	20,12		34,0	127,0	0,0	0,0	0,0		34,0	127,0				0,0	34,0	127,0
ANGRA 1 (640)	Nuclear	31,17	640,0	640,0	640,0	0,0	0,0	0,0	640,0	640,0	640,0				640,0	640,0	640,0
NORTEFLU 1 (400)	Gás	84,73	400,0	400,0	400,0	0,0	0,0	0,0	400,0	400,0	400,0				400,0	400,0	400,0
NORTEFLU 2 (100)	Gás	96,23	100,0	100,0	100,0	0,0	0,0	0,0	100,0	100,0	100,0				100,0	100,0	100,0
O.PINTADA (50)	Biomassa	112,47	5,0	5,0	5,0	45,0	45,0	45,0	50,0	50,0	50,0				50,0	50,0	50,0
UTE STA VI (41)	Biomassa	121,49	13,0	13,0	13,0	28,4	28,4	28,4	41,4	41,4	41,4				41,4	41,4	41,4
PREDILECTA (5)	Biomassa	158,95	1,0	1,0	1,0	4,0	4,0	4,0	5,0	5,0	5,0				5,0	5,0	5,0
NORTEFLU 3 (200)	Gás	183,63	100,0	100,0	100,0	100,0	100,0	100,0	200,0	200,0	200,0				200,0	200,0	200,0
ATLANTICO (235)	Resíduos	199,08	218,7	218,7	218,7	0,0	0,0	0,0	218,7	218,7	218,7				218,7	218,7	218,7
BAIXADA FL (530)	Gás	201,85				530,0	530,0	530,0	530,0	530,0	530,0				530,0	530,0	530,0
SANTA CRUZ (500)	GNL	204,96				350,0	350,0	350,0	350,0	350,0	350,0				350,0	350,0	350,0
T.LAGOAS (350)	Gás	262,08				180,0	180,0	180,0	180,0	180,0	180,0				180,0	180,0	180,0
JUIZ DE FO (87)	Gás	283,74				84,8	84,8	84,8	84,8	84,8	84,8				84,8	84,8	84,8
ST.CRUZ 34 (436)	Óleo	310,41															
LUIZORMELO (204)	GNL	312,25										196,0	196,0	196,0	196,0	196,0	196,0
TERMORIO (1036)	Gás	328,83				514,7	514,7	514,7	514,7	514,7	514,7				514,7	514,7	514,7
CUBATAO (216)	Gás	345,29				209,0	209,0	209,0	209,0	209,0	209,0				209,0	209,0	209,0
SEROPEDICA (386)	Gás	409,94				265,0	265,0		265,0	265,0					265,0	265,0	0,0
PIRAT.12 O (200)	Gás	470,34															
IBIRITE (226)	Gás	482,95															
NPIRATINGA (572)	Gás	548,04															
NORTEFLU 4 (127)	Gás	595,49															
CUIABA CC (529)	Gás	675,63															
T.MACAE (929)	Gás	737,31															
PALMEIR_GO (176)	Diesel	762,23															
TNORTE 2 (340)	Óleo	910,86															
VIANA (175)	Óleo	946,60															
CAMPOS (25)	Gás	978,10															
DAIA (44)	Diesel	1018,60															
GOIANIA 2 (140)	Diesel	1065,35															
XAVANTES (54)	Diesel	1463,86															
TOTAL SE/CO (10558)			1639,7	1673,7	1766,7	2310,9	2310,9	2045,9	3950,6	3984,6	3812,6	196,0	196,0	196,0	4146,6	4180,6	4008,6

REGIÃO SUL																	
Térmicas Potência (MW)	Combustível	CVU (R$/MWh)	Inflexibilidade			Ordem de Mérito			Total Mérito e INFL.			Razão Elétrica			Total UTE		
			P	M	L	P	M	L	P	M	L	P	M	L	P	M	L
URUGUAIANA (640)	Gás	0,00															
PAMPA SUL (345)	Carvão	69,75				0,0	0,0	0,0	0,0	0,0	0,0				0,0	0,0	0,0
SAO SEPE (8)	Biomassa	87,75	5,0	5,0	5,0	0,0	0,0	0,0	5,0	5,0	5,0				5,0	5,0	5,0
CANDIOTA_3 (350)	Carvão	89,47	325,0	325,0	325,0	0,0	0,0	0,0	325,0	325,0	325,0				325,0	325,0	325,0
J.LACER. C (363)	Carvão	206,84				0,0	0,0	0,0	0,0	0,0	0,0				0,0	0,0	0,0
J.LACER. B (262)	Carvão	244,14				262,0	262,0	262,0	262,0	262,0	262,0				262,0	262,0	262,0
J.LAC. A2 (132)	Carvão	245,21				132,0	132,0	132,0	132,0	132,0	132,0				132,0	132,0	132,0
J.LAC. A1 (100)	Carvão	270,48				100,0	100,0	100,0	100,0	100,0	100,0				100,0	100,0	100,0
MADEIRA (4)	Biomassa	320,44	2,0	2,0	2,0	1,0	1,0	1,0	3,0	3,0	3,0				3,0	3,0	3,0
FIGUEIRA (20)	Carvão	475,68															
CANOAS (249)	Diesel	698,14															
ARAUCARIA (484)	Gás	1054,56															
TOTAL SUL (2957)			332,0	332,0	332,0	495,0	495,0	495,0	827,0	827,0	827,0	0,0	0,0	0,0	827,0	827,0	827,0

O conteúdo desta publicação foi produzido pelo ONS com base em dados e informações de conhecimento público. É de responsabilidade exclusiva dos agentes e demais interessados a obtenção de outros dados e informações, a realização de análises, estudos e avaliações para fins de tomada de decisões, definição de estratégias de atuação, assunção de compromissos e obrigações e quaisquer outras finalidades, em qualquer tempo e sob qualquer condição. É proibida a reprodução ou utilização total ou parcial do presente sem a identificação da fonte.

REGIÃO NORDESTE

Térmicas Potência (MW)	Combustível	CVU (R$/MWh)	Inflexibilidade			Ordem de Mérito			Total Mérito e INFL.			Razão Elétrica			Total UTE		
			P	M	L	P	M	L	P	M	L	P	M	L	P	M	L
ALTOS (13)	Diesel	0,00															
ARACATI (11)	Diesel	0,00															
BATURITE (11)	Diesel	0,00															
C.MAIOR (13)	Diesel	0,00															
CAUCAIA (15)	Diesel	0,00															
CRATO (13)	Diesel	0,00															
IGUATU (15)	Diesel	0,00															
JUAZEIRO N (15)	Diesel	0,00															
MARAMBAIA (13)	Diesel	0,00															
NAZARIA (13)	Diesel	0,00															
PECEM (15)	Diesel	0,00															
ERB CANDEI (17)	Biomassa	87,81	4,5	4,5	4,5	6,5	6,5	6,5	11,0	11,0	11,0				11,0	11,0	11,0
PROSPERIDA (28)	Gás	165,61	28,0	28,0	28,0	0,0	0,0	0,0	28,0	28,0	28,0				28,0	28,0	28,0
TERMOPE (533)	Gás	190,32	532,7	532,7	532,7	0,0	0,0	0,0	532,7	532,7	532,7				532,7	532,7	532,7
P.PECEM1 (720)	Carvão	233,97				720,0	720,0	720,0	720,0	720,0	720,0				720,0	720,0	720,0
P.PECEM2 (365)	Carvão	241,56				365,0	365,0	365,0	365,0	365,0	365,0				365,0	365,0	365,0
FORTALEZA (327)	Gás	245,46				326,6	326,6	326,6	326,6	326,6	326,6				326,6	326,6	326,6
PSERGIPE I (1516)	GNL	301,28															
TERMOCEARA (223)	Gás	430,00															
SYKUE I (30)	Biomassa	510,12															
VALE ACU (368)	Gás	526,79															
T.BAHIA (186)	Gás	537,33															
PERNAMBU_3 (201)	Óleo	816,54															
BAHIA_1 (31)	Óleo	817,22															
MARACANAU (168)	Óleo	920,98															
TERMOCABO (50)	Óleo	934,98															
TERMONE (171)	Óleo	938,29															
TERMOPB (171)	Óleo	938,29															
CAMPINA_GR (169)	Óleo	946,62															
SUAPE II (381)	Óleo	968,43															
POTIGUAR_3 (66)	Diesel	1002,31															
POTIGUAR (53)	Diesel	1002,32															
AREMBEPE (150)	Óleo	1021,02															
MURICY (147)	Óleo	1021,02															
GLOBAL I (149)	Óleo	1072,45															
GLOBAL II (149)	Óleo	1072,45															
PETROLINA (136)	Óleo	1120,20															
PAU FERRO (94)	Diesel	1134,71															
TERMOMANAU (143)	Diesel	1134,71															
TOTAL NE (6889)			565,2	565,2	565,2	1418,1	1418,1	1418,1	1983,3	1983,3	1983,3	0,0	0,0	0,0	1983,3	1983,3	1983,3

REGIÃO NORTE

Térmicas Potência (MW)	Combustível	CVU (R$/MWh)	Inflexibilidade			Ordem de Mérito			Total Mérito e INFL.			Razão Elétrica			Total UTE		
			P	M	L	P	M	L	P	M	L	P	M	L	P	M	L
C. ROCHA (85)	Gás	0,00	65,0	65,0	65,0				65,0	65,0	65,0				65,0	65,0	65,0
JARAQUI (75)	Gás	0,00	63,0	63,0	63,0				63,0	63,0	63,0				63,0	63,0	63,0
MANAUARA (67)	Gás	0,00	64,5	64,5	64,5				64,5	64,5	64,5				64,5	64,5	64,5
PONTA NEGR (66)	Gás	0,00	64,0	64,0	64,0				64,0	64,0	64,0				64,0	64,0	64,0
TAMBAQUI (93)	Gás	0,00	63,0	63,0	63,0				63,0	63,0	63,0				63,0	63,0	63,0
MARANHAO3 (519)	Gás	85,72	490,0	490,0	490,0	4,8	25,3	22,7	494,8	515,3	512,7				494,8	515,3	512,7
APARECIDA (166)	Gás	98,28	75,0	75,0	75,0	66,0	68,6	71,5	141,0	143,6	146,5				141,0	143,6	146,5
UTE MAUA 3 (591)	Gás	98,28	264,0	264,0	264,0	199,8	199,8	199,8	463,8	463,8	463,8				463,8	463,8	463,8
PARNAIB_IV (56)	Gás	151,69				37,5	37,5	37,5	37,5	37,5	37,5				37,5	37,5	37,5
MARAN_VL_7 (336)	Gás	189,11				326,0	334,9	333,8	326,0	334,9	333,8				326,0	334,9	333,8
MARAN_VL22 (1)	Gás	189,11				1,1	1,1	1,1	1,1	1,1	1,1				1,1	1,1	1,1
MARANIVL_7 (336)	Gás	189,11				325,9	334,9	333,7	325,9	334,9	333,7				325,9	334,9	333,7
MARANIVL22 (1)	Gás	189,11				1,1	1,1	1,1	1,1	1,1	1,1				1,1	1,1	1,1
N.VEN2_L22 (27)	Gás	232,01				27,0	27,0	27,0	27,0	27,0	27,0				27,0	27,0	27,0
N.VEN2_L7 (151)	Gás	232,27				144,4	150,2	149,4	144,4	150,2	149,4				144,4	150,2	149,4
P. ITAQUI (360)	Carvão	235,54				360,1	360,1	360,1	360,1	360,1	360,1				360,1	360,1	360,1
GERAMAR1 (166)	Óleo	946,58															
GERAMAR2 (166)	Óleo	946,58															
TOTAL NORTE (3264)			1148,5	1148,5	1148,5	1493,7	1540,5	1537,7	2642,2	2689,0	2686,2	0,0	0,0	0,0	2642,2	2689,0	2686,2

O conteúdo desta publicação foi produzido pelo ONS com base em dados e informações de conhecimento público. É de responsabilidade exclusiva dos agentes e demais interessados a obtenção de outros dados e informações, a realização de análises, estudos e avaliações para fins de tomada de decisões, definição de estratégias de atuação, assunção de compromissos e obrigações e quaisquer outras finalidades, em qualquer tempo e sob qualquer condição. É proibida a reprodução ou utilização total ou parcial do presente sem a identificação da fonte.