1. APRESENTAÇÃO

No início da semana de 12/06 a 18/06/2021, com o avanço de uma frente fria pelo litoral da região Sudeste/Centro-Oeste, ocorreu chuva fraca na bacia do rio Doce e em pontos isolados do Jequitinhonha.

Na semana de 19/06 a 25/06/2021, devido a atuação em áreas de instabilidade no início da semana e avanço de frente fria ao fim da semana, é esperado que as bacias dos rios Iguaçu e Uruguai, além do trecho incremental a UHE Itaipu, apresentem totais elevados de precipitação.

Para a semana operativa de 19/06 a 25/06/2021, houve oferta de energia da República Oriental do Uruguai e da República da Argentina. De acordo com o Art. 2º da Portaria MME nº 339, de 15 de agosto de 2018, as ofertas para importação de energia não foram consideradas na elaboração do PMO.

Os valores médios semanais do Custo Marginal de Operação – CMO dos subsistemas do SIN sofreram as seguintes alterações em relação à semana anterior:

- SE/CO: de R$ 434,26/MWh para R$ 682,22/MWh
- Sul: de R$ 434,26/MWh para R$ 682,22/MWh
- Nordeste: de R$ 296,14/MWh para R$ 440,56/MWh
- Norte: de R$ 426,30/MWh para R$ 682,22/MWh

Desde o dia 01/01/2020, o despacho por ordem de mérito é indicado diariamente pelos resultados do modelo DESSEM. Assim, o despacho por ordem de mérito semanal, conforme publicado nesse documento, tem caráter apenas informativo. Da mesma forma, desde o dia 01/01/2021, a formação de preço deixou o formato semanal/patamar de carga e passou a ser horário, de acordo também com os resultados do modelo DESSEM.

2. NOTÍCIAS

Nos dias 24 e 25 de junho será realizada a reunião de elaboração do PMO Julho de 2021, com transmissão ao vivo através do site do ONS.

Como medida adicional de prevenção ao Coronavírus, o ONS informa que está suspensa, temporariamente, a participação presencial nas reuniões

3. ANÁLISE DAS CONDIÇÕES HIDROMETEOROLÓGICAS

3.1. PREVISÃO PARA A PRÓXIMA SEMANA

As bacias hidrográficas da região Sul apresentam totais elevados de precipitação devido a atuação de áreas de instabilidade no início da semana e o avanço de uma frente fria no fim da semana, com destaque para as bacias dos rios Iguaçu e Uruguai e o trecho incremental a UHE Itaipu. (**Figura 1**).

O conteúdo desta publicação foi produzido pelo ONS com base em dados e informações de conhecimento público. É de responsabilidade exclusiva dos agentes e demais interessados a obtenção de outros dados e informações, a realização de análises, estudos e avaliações para fins de tomada de decisões, definição de estratégias de atuação, assunção de compromissos e obrigações e quaisquer outras finalidades, em qualquer tempo e sob qualquer condição. É proibida a reprodução ou utilização total ou parcial do presente sem a identificação da fonte.

Figura 1 - Precipitação acumulada prevista pelo modelo ECMWF (ECMWF) para o período de 19/06/2021 a 25/06/2021.

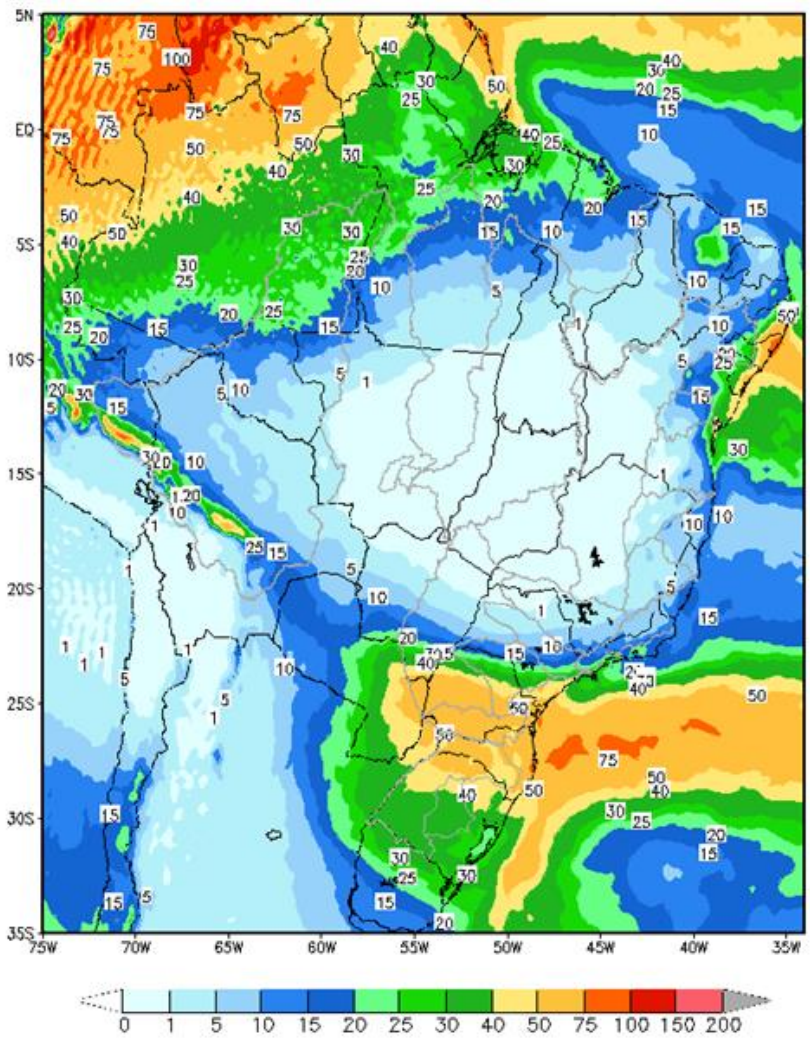

Em comparação com os valores estimados para a semana em curso, prevê-se para a próxima semana operativa recessão nas afluências dos subsistemas Sudeste/Centro-Oeste e Norte, ascensão nas afluências do subsistema Sul e estabilidade nas afluências do subsistema Nordeste. A previsão mensal para junho indica a ocorrência de afluências abaixo da média histórica para todos os subsistemas.

Tabela 1 – Previsão de ENAs da Revisão 3 de Junho/2021

Revisão 3 do PMO de Junho/2021 - ENAs previstas				
Subsistema	19/06 a 25/06/2021		Mês de junho	
	MWmed	%MLT	MWmed	%MLT
SE/CO	20.378	62	21.690	66
S	5.421	52	5.252	50
NE	1.774	38	1.770	38
N	6.559	61	7.698	72

O conteúdo desta publicação foi produzido pelo ONS com base em dados e informações de conhecimento público. É de responsabilidade exclusiva dos agentes e demais interessados a obtenção de outros dados e informações, a realização de análises, estudos e avaliações para fins de tomada de decisões, definição de estratégias de atuação, assunção de compromissos e obrigações e quaisquer outras finalidades, em qualquer tempo e sob qualquer condição. É proibida a reprodução ou utilização total ou parcial do presente sem a identificação da fonte.

4. PREVISÃO DE CARGA

Para o mês de junho/21 as previsões de carga consolidadas levaram em consideração a expectativa de manutenção da produção industrial em patamares elevados, principalmente daquelas indústrias voltadas para exportação. A melhora do setor externo graças à recuperação da economia mundial, devido ao controle da pandemia em países como: Estados Unidos, parte da Europa e China tem contribuído para o desempenho desse setor.

As previsões meteorológicas indicam para a próxima semana operativa, temperaturas semelhantes às observadas na semana em curso para todas as regiões do Brasil, com os seguintes destaques:

- ✓ Regiões SE/CO e SUL: Expectativa de ocorrência de temperaturas amenas, comportamento típico para essa época do ano.
- ✓ Regiões Nordeste e Norte: Destaca-se a expectativa de maiores totais de precipitação em Recife e São Luís, em relação a semana em curso.

As taxas de crescimento previstas para o mês de junho em relação ao mesmo mês do ano anterior, são de 7,2% para os subsistemas Sudeste/Centro-Oeste, 6,2% para o subsistema Sul, 11,3% no Nordeste e 11,0% no subsistema do Norte.

Tabela 2 – Evolução da carga do PMO de junho 2021

Subsistema	CARGA SEMANAL (MWmed)					CARGA MENSAL (MWmed)	
	1ª Sem	2ª Sem	3ª Sem	4ª Sem	5ª Sem	jun/21	Var. (%) jun/21 -> jun/20
SE/CO	38.906	39.086	37.647	38.361	37.806	38.344	7,2%
Sul	11.114	11.386	11.391	11.413	11.423	11.363	6,2%
Nordeste	11.055	11.069	11.080	10.775	10.857	10.966	11,3%
Norte	6.013	6.008	5.914	5.975	5.949	5.969	11,0%
SIN	67.088	67.549	66.032	66.524	66.035	66.642	8,0%

O conteúdo desta publicação foi produzido pelo ONS com base em dados e informações de conhecimento público. É de responsabilidade exclusiva dos agentes e demais interessados a obtenção de outros dados e informações, a realização de análises, estudos e avaliações para fins de tomada de decisões, definição de estratégias de atuação, assunção de compromissos e obrigações e quaisquer outras finalidades, em qualquer tempo e sob qualquer condição. É proibida a reprodução ou utilização total ou parcial do presente sem a identificação da fonte.

5. PRINCIPAIS RESULTADOS

5.1. CUSTO MARGINAL DE OPERAÇÃO (CMO)

A tabela a seguir apresenta o CMO, por subsistema e patamar de carga para próxima semana operativa.

Tabela 3 – CMO por patamar de carga

Patamares de Carga	CMO (R$/MWh)			
	SE/CO	S	NE	N
Pesada	700,26	700,26	443,92	700,26
Média	699,68	699,68	443,91	699,68
Leve	660,11	660,11	436,40	660,11
Média Semanal	682,22	682,22	440,56	682,22

Na figura a seguir é apresentada a evolução do CMO médio semanal ao longo deste PMO.

Figura 2 – Evolução semanal do CMO

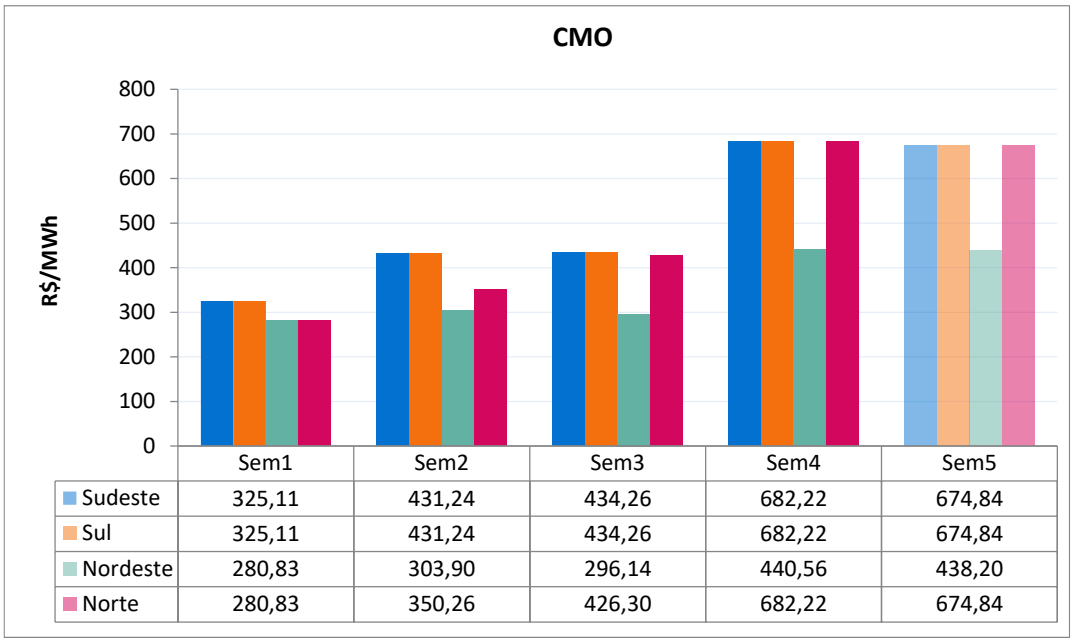

	Sem1	Sem2	Sem3	Sem4	Sem5
Sudeste	325,11	431,24	434,26	682,22	674,84
Sul	325,11	431,24	434,26	682,22	674,84
Nordeste	280,83	303,90	296,14	440,56	438,20
Norte	280,83	350,26	426,30	682,22	674,84

5.2. POLÍTICA DE OPERAÇÃO ENERGÉTICA

Para esta semana operativa, está prevista a seguinte política de intercâmbio de energia entre regiões:

Região SE/CO → Geração minimizada de acordo com os condicionantes hidráulicos.

Região Sul → Geração dimensionada para fechamento do balanço energético do SIN.

Região NE → Aumento da geração eólica e possível exportação de energia, modulando em função de seus recursos energéticos, respeitando-se os limites elétricos vigentes.

Região Norte → Redução das vazões, com a geração sendo dimensionada a partir da vazão afluente verificada.

O conteúdo desta publicação foi produzido pelo ONS com base em dados e informações de conhecimento público. É de responsabilidade exclusiva dos agentes e demais interessados a obtenção de outros dados e informações, a realização de análises, estudos e avaliações para fins de tomada de decisões, definição de estratégias de atuação, assunção de compromissos e obrigações e quaisquer outras finalidades, em qualquer tempo e sob qualquer condição. É proibida a reprodução ou utilização total ou parcial do presente sem a identificação da fonte.

6. ANÁLISE DA VARIAÇÃO SEMANAL DO CMO

Esta análise visa identificar os principais parâmetros cujas atualizações impactaram os CMO deste PMO, em comparação com os valores obtidos na última revisão.

Foram realizados 8 estudos, onde o caso inicial foi construído com base nos dados oficiais da última revisão deste PMO. Neste primeiro estudo, denominado de "previsão perfeita", a partida dos reservatórios foi estimada conforme indicado para esta semana na última revisão.

O segundo estudo foi realizado com os dados do caso inicial sendo substituída a previsão de vazões. A partir do conjunto de dados do segundo estudo, foram elaborados os demais casos em que foram atualizadas, sequencialmente, as seguintes informações: níveis de partida dos reservatórios, previsão de carga, disponibilidade das usinas térmicas e hidráulicas, restrições de limites de intercâmbio, restrições hidráulicas e, por fim, os demais dados que compõem toda informação referente a atual revisão.

Os custos marginais de operação dos subsistemas Sudeste/Centro-Oeste, Sul e Norte estão acoplados e são apresentados nas Figura 3 e 4, respectivamente. Para estes subsistemas, como pode ser observado no resultado do estudo denominado "previsão perfeita", já era prevista a elevação do CMO. Entretanto, o fator que mais contribuiu para esta forte elevação dos CMO nesta revisão foi a atualização das restrições hidráulicas. Outros fatores que também influenciaram na elevação do CMO dos subsistemas SE/CO, S e N foram as atualizações da previsão de vazões e dos níveis de partida dos reservatórios.

Os custos marginais de operação do subsistema Nordeste estão desacoplados com os outros subsistemas e a variação do CMO pode ser vista na Figura 5.

Para o subsistema Nordeste também houve significativa elevação no CMO em relação à semana anterior, acarretado principalmente pela atualização das restrições hidráulicas.

Figura 3 – Análise da variação do CMO nos subsistemas SE/CO

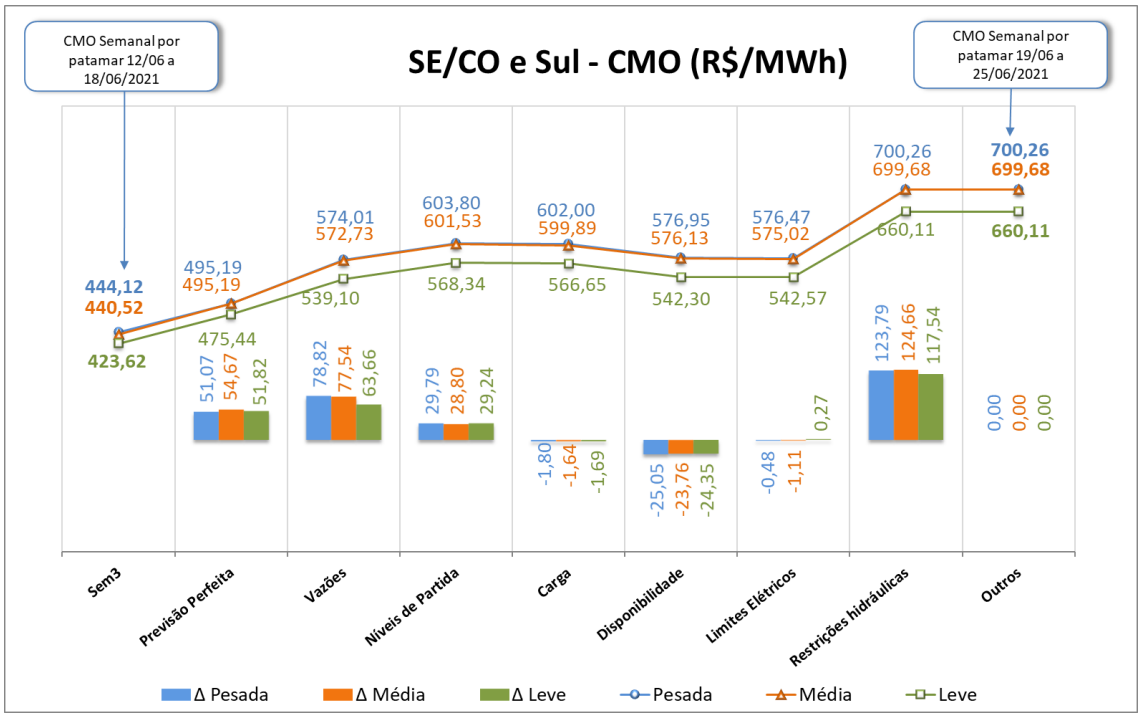

O conteúdo desta publicação foi produzido pelo ONS com base em dados e informações de conhecimento público. É de responsabilidade exclusiva dos agentes e demais interessados a obtenção de outros dados e informações, a realização de análises, estudos e avaliações para fins de tomada de decisões, definição de estratégias de atuação, assunção de compromissos e obrigações e quaisquer outras finalidades, em qualquer tempo e sob qualquer condição. É proibida a reprodução ou utilização total ou parcial do presente sem a identificação da fonte.

Figura 4 – Análise da variação do CMO nos subsistemas Norte

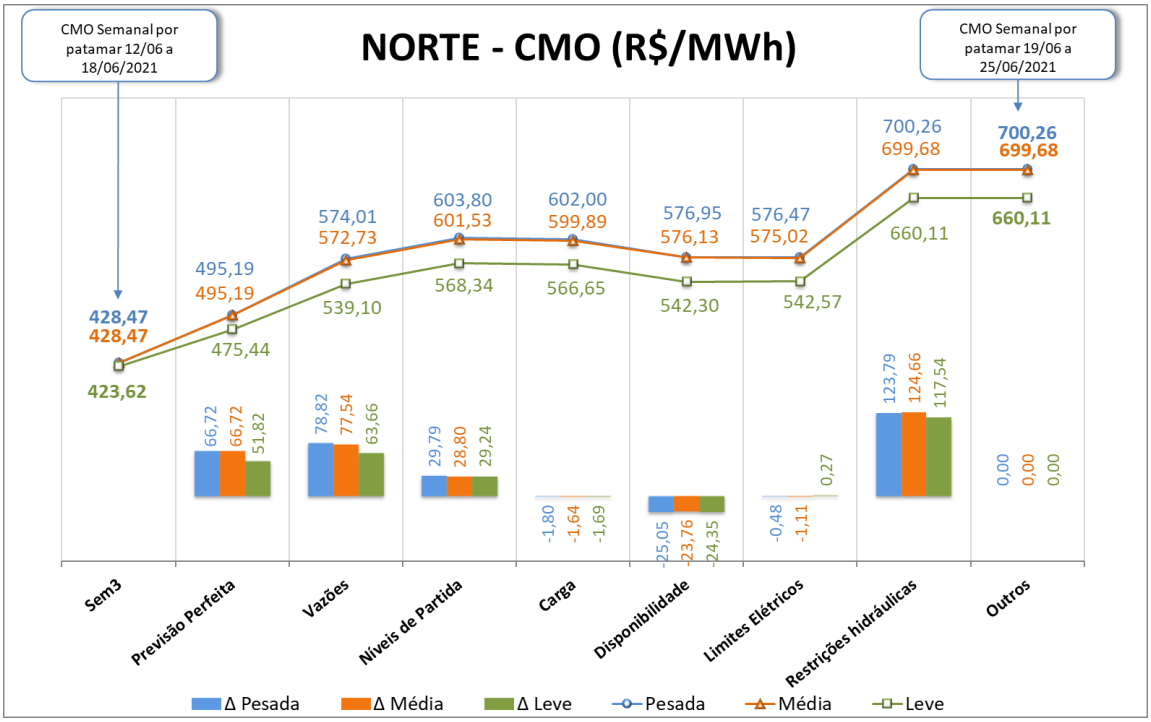

Figura 5 – Análise da variação do CMO nos subsistemas Nordeste

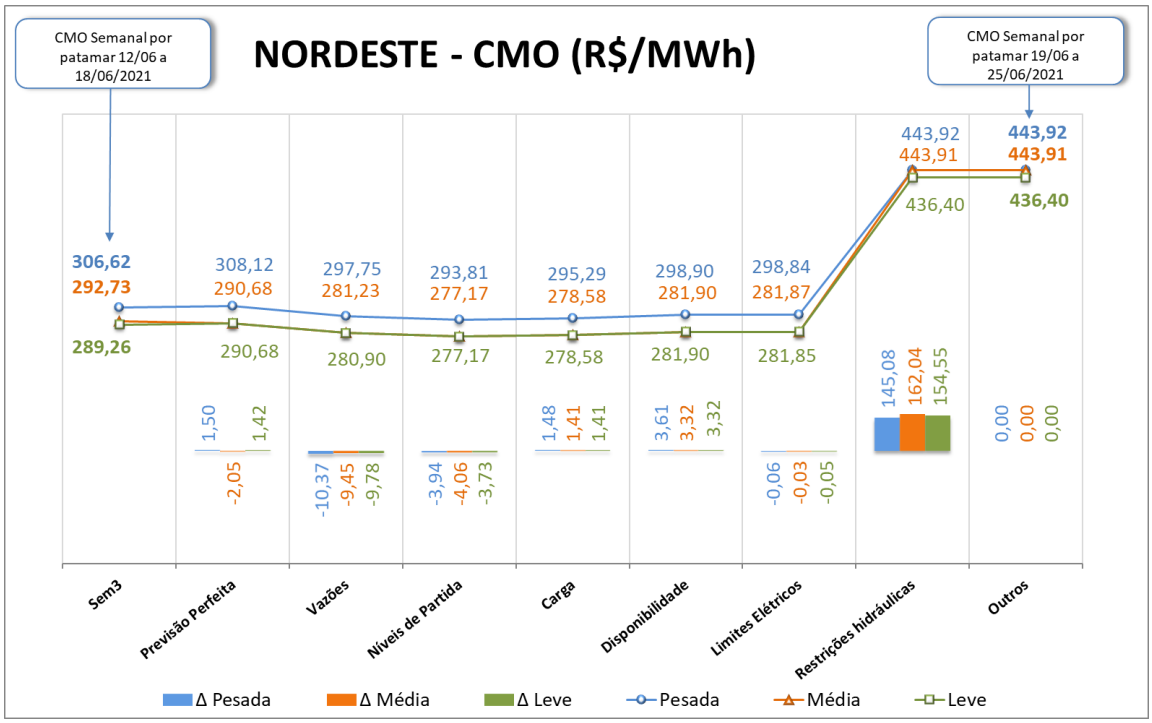

O conteúdo desta publicação foi produzido pelo ONS com base em dados e informações de conhecimento público. É de responsabilidade exclusiva dos agentes e demais interessados a obtenção de outros dados e informações, a realização de análises, estudos e avaliações para fins de tomada de decisões, definição de estratégias de atuação, assunção de compromissos e obrigações e quaisquer outras finalidades, em qualquer tempo e sob qualquer condição. É proibida a reprodução ou utilização total ou parcial do presente sem a identificação da fonte.

7. GERAÇÃO TÉRMICA

A Figura 6 apresenta, para cada subsistema, o despacho térmico por modalidade indicado pelo Decomp para a próxima semana operativa.

Figura 6 – Geração térmica para a próxima semana operativa

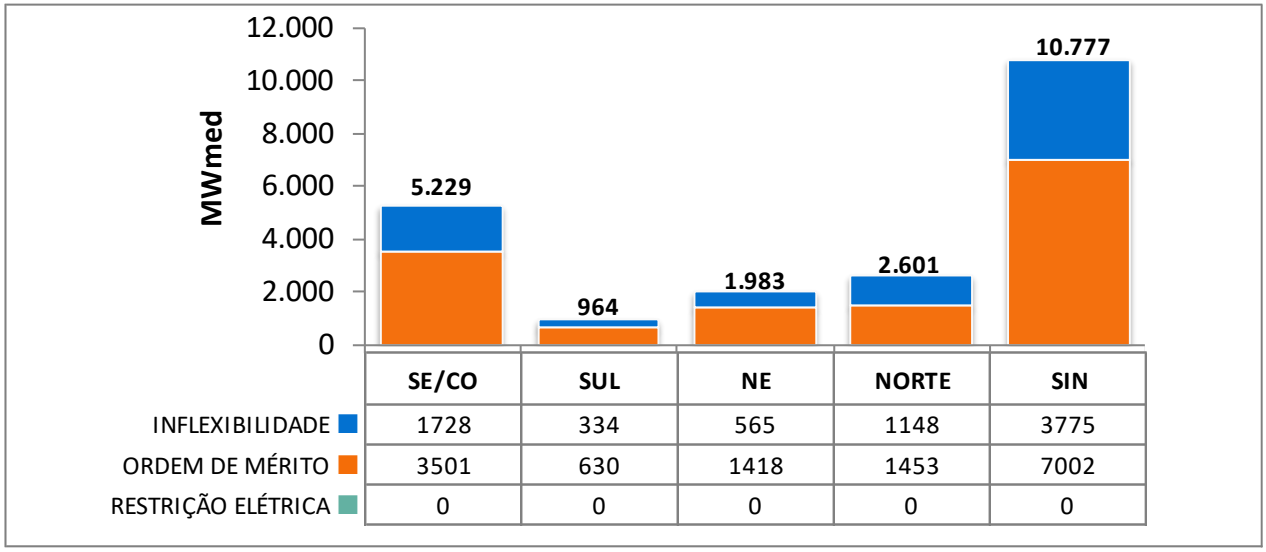

Na tabela abaixo segue a indicação de despacho antecipado por ordem de mérito de custo para a semana de 21/08/2021 a 27/08/2021.

Tabela 4 – UTEs com contrato de combustível GNL

UTE			Benefício (R$/MWh)		
Nome	Cod	CVU (R$/MWh)	Carga Pesada	Carga Média	Carga Leve
SANTA CRUZ	86	199,25	880,94 (1)	880,94 (1)	880,55 (1)
LUIZORMELO	15	303,14	880,94 (1)	880,94 (1)	880,55 (1)
PSERGIPE I	224	304,16	283,49 (2)	283,49 (2)	283,47 (2)

(1) Comandado o despacho antecipado por ordem de mérito de custo nesse patamar

(2) NÃO foi comandado o despacho antecipado por ordem de mérito de custo nesse patamar

Assim sendo, há previsão de despacho antecipado por ordem de mérito de custo para as UTE Santa Cruz e Luiz O. R. Melo, para a semana de 21/08 a 27/08/2021.

Ressalta-se que, conforme declaração do agente, a UTE Luiz O. R. Melo tem parada programada para o período entre 15/08 e 13/09/2021.

Embora a UTE Porto Sergipe I não esteja despachada por ordem de mérito de custo, o ONS comanda seu despacho antecipado em sua totalidade, para a semana de 21/08 a 27/08/2021.

O conteúdo desta publicação foi produzido pelo ONS com base em dados e informações de conhecimento público. É de responsabilidade exclusiva dos agentes e demais interessados a obtenção de outros dados e informações, a realização de análises, estudos e avaliações para fins de tomada de decisões, definição de estratégias de atuação, assunção de compromissos e obrigações e quaisquer outras finalidades, em qualquer tempo e sob qualquer condição. É proibida a reprodução ou utilização total ou parcial do presente sem a identificação da fonte.

8. IMPORTAÇÃO DE ENERGIA DA REPÚBLICA ORIENTAL DO URUGUAI

8.1. República Oriental do Uruguai

Para a próxima semana operativa, foram declaradas as seguintes ofertas de importação de energia da República Oriental do Uruguai para o Sistema Interligado Nacional - SIN através das conversoras de Rivera (70 MW) e Melo (500 MW).

- **Eletrobras**

Tabela 5 – Energia ofertada para importação

	Oferta de Energia para a Semana de 19/06 a 25/06 (MWmed)			
	Bloco 1	Bloco 2	Bloco 3	Total
Carga Pesada	70	90	135	295
Carga Média	70	90	135	295
Carga Leve	70	90	135	295
CVU (R$/MWh)	779,46	1.037,41	1.216,51	

- **Enel**

Conforme declaração do agente, esta importação poderá ser realizada exclusivamente pela conversora Melo.

Tabela 6 – Energia ofertada para importação

	Oferta de Energia para a Semana de 19/06 a 25/06 (MWmed)			
	Bloco 1	Bloco 2	Bloco 3	Total
Carga Pesada	50	90	135	275
Carga Média	50	90	135	275
Carga Leve	50	90	135	275
CVU (R$/MWh)	801,20	1.065,41	1.250,98	

O conteúdo desta publicação foi produzido pelo ONS com base em dados e informações de conhecimento público. É de responsabilidade exclusiva dos agentes e demais interessados a obtenção de outros dados e informações, a realização de análises, estudos e avaliações para fins de tomada de decisões, definição de estratégias de atuação, assunção de compromissos e obrigações e quaisquer outras finalidades, em qualquer tempo e sob qualquer condição. É proibida a reprodução ou utilização total ou parcial do presente sem a identificação da fonte.

8.2. República da Argentina

- **Enel**

Para a próxima semana operativa, foi declarada a seguinte oferta de importação de energia da República da Argentina para o SIN através das conversoras de Garabi 1 (1.100 MW) e Garabi 2 (1.100 MW).

Tabela 7 – Energia ofertada para importação

	Oferta de Energia para a Semana de 19/06 a 25/06 (MWmed)	
	Bloco 1	Total
Carga Pesada	400	400
Carga Média	400	400
Carga Leve	400	400
CVU (R$/MWh)	1.323,47	

Nota: Detalhes sobre a importação de energia vide Portaria Nº 339, de 15 de Agosto de 2018 disponível em: http://pesquisa.in.gov.br/imprensa/jsp/visualiza/index.jsp?data=17/08/2018&jornal=515&pagina=60&totalArquivos=136

O conteúdo desta publicação foi produzido pelo ONS com base em dados e informações de conhecimento público. É de responsabilidade exclusiva dos agentes e demais interessados a obtenção de outros dados e informações, a realização de análises, estudos e avaliações para fins de tomada de decisões, definição de estratégias de atuação, assunção de compromissos e obrigações e quaisquer outras finalidades, em qualquer tempo e sob qualquer condição. É proibida a reprodução ou utilização total ou parcial do presente sem a identificação da fonte.

9. ARMAZENAMENTOS OPERATIVOS

Para uma melhor avaliação de diversos cenários hidrometeorológicos, notadamente, aqueles de curto prazo e suas influências nas previsões de vazões nos subsistemas, os resultados desta revisão do PMO contemplam cenários de afluências visando melhor representar a ocorrência de precipitação e, consequentemente, seus efeitos sobre as afluências e armazenamentos.

Além dos resultados associados ao valor esperado das previsões de afluências, as simulações operativas também foram realizadas com os limites superior e inferior das previsões de afluências. Apresentamos a seguir os resultados obtidos com a aplicação dos diferentes cenários de afluência.

Tabela 8 – Previsão de ENA dos cenários de sensibilidade

Subsistema	ENERGIAS NATURAIS AFLUENTES					
	Previsão Mensal					
	LI		VE		LS	
	(MWmed)	%MLT	(MWmed)	%MLT	(MWmed)	%MLT
SE/CO	20.837	**64**	21.690	**66**	22.541	**69**
Sul	4.097	**39**	5.252	**50**	6.394	**61**
Nordeste	1.726	**37**	1.770	**38**	1.813	**39**
Norte	7.459	**70**	7.698	**72**	7.936	**74**

Tabela 9 – Previsão de %EARmáx para o final do mês

Subsistema	% EARmáx 18/06	% EARmáx - 30/06		
	NÍVEL INICIAL	NÍVEL PMO		
	VE	LI	VE	LS
SE/CO	**30,0**	**28,4**	**28,7**	**29,1**
Sul	**60,7**	**61,9**	**66,0**	**69,5**
Nordeste	**60,8**	**59,1**	**59,3**	**59,3**
Norte	**83,7**	**70,5**	**71,3**	**72,0**

O conteúdo desta publicação foi produzido pelo ONS com base em dados e informações de conhecimento público. É de responsabilidade exclusiva dos agentes e demais interessados a obtenção de outros dados e informações, a realização de análises, estudos e avaliações para fins de tomada de decisões, definição de estratégias de atuação, assunção de compromissos e obrigações e quaisquer outras finalidades, em qualquer tempo e sob qualquer condição. É proibida a reprodução ou utilização total ou parcial do presente sem a identificação da fonte.

10. RESERVATÓRIOS EQUIVALENTES DE ENERGIA

A seguir são apresentadas as previsões de Energia Natural Afluente para a próxima semana operativa e para o mês de junho, bem como as previsões de Energia Armazenada nos Reservatórios Equivalentes de Energia – REE, desta revisão do PMO.

Tabela 10 – Previsão de ENA por REE

Valor Esperado das Energias Naturais Afluentes				
REE	Previsão Semanal		Previsão Mensal	
	19/06/2021 a 25/06/2021		jun-21	
	(MWmed)	%MLT	(MWmed)	%MLT
Sudeste	2.172	62	2.326	66
Madeira	6.078	100	6.269	103
Teles Pires	943	70	1.076	79
Itaipu	2.328	64	2.459	68
Paraná	7.425	48	8.039	52
Paranapanema	1.121	43	1.206	46
Sul	3.934	75	3.997	76
Iguaçu	1.488	28	1.256	24
Nordeste	1.774	38	1.770	38
Norte	2.536	57	2.870	65
Belo Monte	2.153	45	3.022	63
Manaus	2.009	135	2.135	143

Tabela 11 – Previsão de %EARmáx por REE

% Energia Armazenável Máxima		
REE	Previsão Semanal	Previsão Mensal
	25-jun	30-jun
	(%EARmáx)	(%EARmáx)
Sudeste	39,3	38,9
Madeira	88,7	88,1
Teles Pires	69,5	68,1
Itaipu	17,1	27,5
Paraná	24,4	23,7
Paranapanema	40,4	40,8
Sul	58,8	62,2
Iguaçu	67,2	69,4
Nordeste	59,9	59,3
Norte	76,2	70,2
Belo Monte	100,0	100,0
Manaus	90,1	89,7

O conteúdo desta publicação foi produzido pelo ONS com base em dados e informações de conhecimento público. É de responsabilidade exclusiva dos agentes e demais interessados a obtenção de outros dados e informações, a realização de análises, estudos e avaliações para fins de tomada de decisões, definição de estratégias de atuação, assunção de compromissos e obrigações e quaisquer outras finalidades, em qualquer tempo e sob qualquer condição. É proibida a reprodução ou utilização total ou parcial do presente sem a identificação da fonte.

11. DESPACHO TÉRMICO POR MODALIDADE, PATAMAR DE CARGA E USINA

Nas tabelas abaixo, a diferenciação entre geração por inflexibilidade e por ordem de mérito tem caráter informativo, com o objetivo de detalhar a informação de inflexibilidade enviada pelos respectivos agentes para esta revisão do PMO. Ressalta-se que nas etapas de Programação Diária e Tempo Real, o montante despachado nas usinas termelétricas indicadas por ordem de mérito é plenamente intitulado como ordem de mérito.

REGIÃO SUDESTE/CENTRO-OESTE

Térmicas Potência (MW)	Combustível	CVU (R$/MWh)	Inflexibilidade			Ordem de Mérito			Total Mérito e INFL.			Razão Elétrica			Total UTE		
			P	M	L	P	M	L	P	M	L	P	M	L	P	M	L
ATLAN_CSA (255)	Resíduos	0,00	150,0	150,0	150,0				150,0	150,0	150,0				150,0	150,0	150,0
ANGRA 2 (1350)	Nuclear	20,12				0,0	0,0	0,0	0,0	0,0	0,0				0,0	0,0	0,0
ANGRA 1 (640)	Nuclear	31,17	640,0	640,0	640,0	0,0	0,0	0,0	640,0	640,0	640,0				640,0	640,0	640,0
NORTEFLU 1 (400)	Gás	84,73	400,0	400,0	400,0	0,0	0,0	0,0	400,0	400,0	400,0				400,0	400,0	400,0
NORTEFLU 2 (100)	Gás	96,23	100,0	100,0	100,0	0,0	0,0	0,0	100,0	100,0	100,0				100,0	100,0	100,0
O.PINTADA (50)	Biomassa	112,47	5,0	5,0	5,0	45,0	45,0	45,0	50,0	50,0	50,0				50,0	50,0	50,0
UTE STA VI (41)	Biomassa	121,49	13,0	13,0	13,0	28,4	28,4	28,4	41,4	41,4	41,4				41,4	41,4	41,4
PREDILECTA (5)	Biomassa	158,95	1,0	1,0	1,0	4,0	4,0	4,0	5,0	5,0	5,0				5,0	5,0	5,0
NORTEFLU 3 (200)	Gás	183,63	200,0	200,0	200,0	0,0	0,0	0,0	200,0	200,0	200,0				200,0	200,0	200,0
BAIXADA FL (530)	Gás	196,19				530,0	530,0	530,0	530,0	530,0	530,0				530,0	530,0	530,0
ATLANTICO (235)	Resíduos	199,08	218,7	218,7	218,7	0,0	0,0	0,0	218,7	218,7	218,7				218,7	218,7	218,7
SANTA CRUZ (500)	GNL	199,25				350,0	350,0	350,0	350,0	350,0	350,0				350,0	350,0	350,0
T.LAGOAS (350)	Gás	262,08				180,0	180,0	180,0	180,0	180,0	180,0				180,0	180,0	180,0
JUIZ DE FO (87)	Gás	283,74				84,8	84,8	84,8	84,8	84,8	84,8				84,8	84,8	84,8
LUIZORMELO (204)	GNL	303,14															
ST.CRUZ 34 (436)	Óleo	310,41															
TERMORIO (1036)	Gás	328,83				835,0	835,0	835,0	835,0	835,0	835,0				835,0	835,0	835,0
CUBATAO (216)	Gás	345,29				209,0	209,0	209,0	209,0	209,0	209,0				209,0	209,0	209,0
SEROPEDICA (386)	Gás	409,94				354,1	354,1	354,1	354,1	354,1	354,1				354,1	354,1	354,1
PIRAT.12 O (200)	Gás	470,34															
NPIRATINGA (572)	Gás	548,04				264,2	264,2	264,2	264,2	264,2	264,2				264,2	264,2	264,2
IBIRITE (226)	Gás	574,01				222,0	222,0	222,0	222,0	222,0	222,0				222,0	222,0	222,0
NORTEFLU 4 (127)	Gás	595,49				126,0	126,0	126,0	126,0	126,0	126,0				126,0	126,0	126,0
CUIABA CC (529)	Gás	675,63				485,0	485,0		485,0	485,0					485,0	485,0	0,0
T.MACAE (929)	Gás	737,31															
PALMEIR_GO (176)	Diesel	762,23															
TNORTE 2 (340)	Óleo	910,86															
VIANA (175)	Óleo	930,45															
CAMPOS (25)	Gás	978,10															
DAIA (44)	Diesel	1018,60															
GOIANIA 2 (140)	Diesel	1065,35															
XAVANTES (54)	Diesel	1463,86															
TOTAL SE/CO (10558)			1727,7	1727,7	1727,7	3717,5	3717,5	3232,5	5445,2	5445,2	4960,2	0,0	0,0	0,0	5445,2	5445,2	4960,2

REGIÃO SUL

Térmicas Potência (MW)	Combustível	CVU (R$/MWh)	Inflexibilidade			Ordem de Mérito			Total Mérito e INFL.			Razão Elétrica			Total UTE		
			P	M	L	P	M	L	P	M	L	P	M	L	P	M	L
URUGUAIANA (640)	Gás	0,00															
PAMPA SUL (345)	Carvão	69,75				0,0	0,0	0,0	0,0	0,0	0,0				0,0	0,0	0,0
SAO SEPE (8)	Biomassa	87,75	7,0	7,0	7,0	0,0	0,0	0,0	7,0	7,0	7,0				7,0	7,0	7,0
CANDIOTA_3 (350)	Carvão	89,47	325,0	325,0	325,0	0,0	0,0	0,0	325,0	325,0	325,0				325,0	325,0	325,0
J.LACER. C (363)	Carvão	206,84				0,0	0,0	0,0	0,0	0,0	0,0				0,0	0,0	0,0
J.LACER. B (262)	Carvão	244,14				262,0	262,0	262,0	262,0	262,0	262,0				262,0	262,0	262,0
J.LAC. A2 (132)	Carvão	245,21				132,0	132,0	132,0	132,0	132,0	132,0				132,0	132,0	132,0
J.LAC. A1 (100)	Carvão	270,48				100,0	100,0	100,0	100,0	100,0	100,0				100,0	100,0	100,0
MADEIRA (4)	Biomassa	320,44	2,0	2,0	2,0	1,0	1,0	1,0	3,0	3,0	3,0				3,0	3,0	3,0
FIGUEIRA (20)	Carvão	475,68				0,0	0,0	0,0	0,0	0,0	0,0				0,0	0,0	0,0
CANOAS (249)	Diesel	698,14				243,1	243,1		243,1	243,1					243,1	243,1	0,0
ARAUCARIA (484)	Gás	1054,56															
TOTAL SUL (2957)			334,0	334,0	334,0	738,1	738,1	495,0	1072,1	1072,1	829,0	0,0	0,0	0,0	1072,1	1072,1	829,0

O conteúdo desta publicação foi produzido pelo ONS com base em dados e informações de conhecimento público. É de responsabilidade exclusiva dos agentes e demais interessados a obtenção de outros dados e informações, a realização de análises, estudos e avaliações para fins de tomada de decisões, definição de estratégias de atuação, assunção de compromissos e obrigações e quaisquer outras finalidades, em qualquer tempo e sob qualquer condição. É proibida a reprodução ou utilização total ou parcial do presente sem a identificação da fonte.

REGIÃO NORDESTE

Térmicas Potência (MW)	Combustível	CVU (R$/MWh)	Inflexibilidade			Ordem de Mérito			Total Mérito e INFL.			Razão Elétrica			Total UTE		
			P	M	L	P	M	L	P	M	L	P	M	L	P	M	L
ALTOS (13)	Diesel	0,00															
ARACATI (11)	Diesel	0,00															
BATURITE (11)	Diesel	0,00															
C.MAIOR (13)	Diesel	0,00															
CAUCAIA (15)	Diesel	0,00															
CRATO (13)	Diesel	0,00															
IGUATU (15)	Diesel	0,00															
JUAZEIRO N (15)	Diesel	0,00															
MARAMBAIA (13)	Diesel	0,00															
NAZARIA (13)	Diesel	0,00															
PECEM (15)	Diesel	0,00															
ERB CANDEI (17)	Biomassa	87,81	4,5	4,5	4,5	6,5	6,5	6,5	11,0	11,0	11,0				11,0	11,0	11,0
PROSPERIDA (28)	Gás	165,61	28,0	28,0	28,0	0,0	0,0	0,0	28,0	28,0	28,0				28,0	28,0	28,0
TERMOPE (533)	Gás	190,32	532,7	532,7	532,7	0,0	0,0	0,0	532,7	532,7	532,7				532,7	532,7	532,7
FORTALEZA (327)	Gás	245,46				326,6	326,6	326,6	326,6	326,6	326,6				326,6	326,6	326,6
P.PECEM1 (720)	Carvão	265,17				720,0	720,0	720,0	720,0	720,0	720,0				720,0	720,0	720,0
P.PECEM2 (365)	Carvão	271,10				365,0	365,0	365,0	365,0	365,0	365,0				365,0	365,0	365,0
PSERGIPE I (1516)	GNL	304,16															
TERMOCEARA (223)	Gás	430,00				0,0	0,0	0,0	0,0	0,0	0,0				0,0	0,0	0,0
SYKUE I (30)	Biomassa	510,12															
VALE ACU (368)	Gás	618,70															
T.BAHIA (186)	Gás	633,56															
PERNAMBU_3 (201)	Óleo	802,20															
BAHIA_1 (31)	Óleo	817,22															
MARACANAU (168)	Óleo	905,02															
TERMOCABO (50)	Óleo	919,04															
TERMONE (171)	Óleo	922,48															
TERMOPB (171)	Óleo	922,48															
CAMPINA_GR (169)	Óleo	930,47															
SUAPE II (381)	Óleo	951,30															
POTIGUAR_3 (66)	Diesel	1002,31															
POTIGUAR (53)	Diesel	1002,32															
AREMBEPE (150)	Óleo	1021,02															
MURICY (147)	Óleo	1021,02															
GLOBAL I (149)	Óleo	1054,22															
GLOBAL II (149)	Óleo	1054,22															
PETROLINA (136)	Óleo	1120,20															
PAU FERRO (94)	Diesel	1134,71															
TERMOMANAU (143)	Diesel	1134,71															
TOTAL NE (6889)			565,2	565,2	565,2	1418,1	1418,1	1418,1	1983,3	1983,3	1983,3	0,0	0,0	0,0	1983,3	1983,3	1983,3

REGIÃO NORTE

Térmicas Potência (MW)	Combustível	CVU (R$/MWh)	Inflexibilidade			Ordem de Mérito			Total Mérito e INFL.			Razão Elétrica			Total UTE		
			P	M	L	P	M	L	P	M	L	P	M	L	P	M	L
C. ROCHA (85)	Gás	0,00	65,0	65,0	65,0				65,0	65,0	65,0				65,0	65,0	65,0
JARAQUI (75)	Gás	0,00	63,0	63,0	63,0				63,0	63,0	63,0				63,0	63,0	63,0
MANAUARA (67)	Gás	0,00	64,5	64,5	64,5				64,5	64,5	64,5				64,5	64,5	64,5
PONTA NEGR (66)	Gás	0,00	64,0	64,0	64,0				64,0	64,0	64,0				64,0	64,0	64,0
TAMBAQUI (93)	Gás	0,00	63,0	63,0	63,0				63,0	63,0	63,0				63,0	63,0	63,0
MARANHAO3 (519)	Gás	85,72	490,0	490,0	490,0	4,8	25,3	22,7	494,8	515,3	512,7				494,8	515,3	512,7
APARECIDA (166)	Gás	96,11	75,0	75,0	75,0	72,0	72,0	72,0	147,0	147,0	147,0				147,0	147,0	147,0
UTE MAUA 3 (591)	Gás	96,11	264,0	264,0	264,0	115,1	115,1	115,1	379,1	379,1	379,1				379,1	379,1	379,1
PARNAIB_IV (56)	Gás	151,69				56,3	54,0	52,8	56,3	54,0	52,8				56,3	54,0	52,8
MARAN_VL_7 (336)	Gás	183,95				326,0	335,7	328,8	326,0	335,7	328,8				326,0	335,7	328,8
MARAN_VL22 (1)	Gás	183,95				1,1	1,1	1,1	1,1	1,1	1,1				1,1	1,1	1,1
MARANIVL_7 (336)	Gás	183,95				325,9	335,7	328,7	325,9	335,7	328,7				325,9	335,7	328,7
MARANIVL22 (1)	Gás	183,95				1,1	1,1	1,1	1,1	1,1	1,1				1,1	1,1	1,1
N.VEN2_L22 (27)	Gás	232,01				27,0	27,0	27,0	27,0	27,0	27,0				27,0	27,0	27,0
N.VEN2_L7 (151)	Gás	232,27				144,4	150,7	147,2	144,4	150,7	147,2				144,4	150,7	147,2
P. ITAQUI (360)	Carvão	264,93				360,1	360,1	360,1	360,1	360,1	360,1				360,1	360,1	360,1
GERAMAR1 (166)	Óleo	930,43															
GERAMAR2 (166)	Óleo	930,43															
TOTAL NORTE (3264)			1148,5	1148,5	1148,5	1433,8	1477,8	1456,6	2582,3	2626,3	2605,1	0,0	0,0	0,0	2582,3	2626,3	2605,1

O conteúdo desta publicação foi produzido pelo ONS com base em dados e informações de conhecimento público. É de responsabilidade exclusiva dos agentes e demais interessados a obtenção de outros dados e informações, a realização de análises, estudos e avaliações para fins de tomada de decisões, definição de estratégias de atuação, assunção de compromissos e obrigações e quaisquer outras finalidades, em qualquer tempo e sob qualquer condição. É proibida a reprodução ou utilização total ou parcial do presente sem a identificação da fonte.