1. APRESENTAÇÃO

No mês de junho os maiores totais de precipitação ficaram restritos às regiões Sul, Norte, e pontos isolados do Centro-Oeste e Sudeste do país. Apesar da ocorrência de precipitação, destaca-se que o total observado foi abaixo da média histórica para o mês nas bacias hidrográficas de interesse do SIN.

No início da semana de 19/06 a 25/06/2021 houve chuva fraca a moderada nas bacias dos rios Uruguai, Jacuí, Iguaçu, Paranapanema e em pontos isolados da região incremental à UHE de Itaipu.

No início da semana de 26/06 a 02/07/2021 as bacias hidrográficas da região Sul apresentam totais significativos de precipitação, com destaque para as bacias dos rios Jacuí, Uruguai, Iguaçu e o trecho incremental a UHE Itaipu. Na região Norte devem ocorrer pancadas de chuva isoladas nos trechos mais baixos dessas bacias.

Para a semana operativa de 26/06 a 02/07/2021, houve oferta de energia da República Oriental do Uruguai. De acordo com o Art. 2º da Portaria MME nº 339, de 15 de agosto de 2018, as ofertas para importação de energia não foram consideradas na elaboração do PMO. Para a referida semana, não houve oferta de energia da República da Argentina.

Os valores médios semanais do Custo Marginal de Operação – CMO dos subsistemas do SIN sofreram as seguintes alterações em relação à semana anterior:

- SE/CO: de R$ 682,22/MWh para R$ 944,55/MWh
- Sul: de R$ 682,22/MWh para R$ 944,55/MWh
- Nordeste: de R$ 440,56/MWh para R$ 944,55/MWh
- Norte: de R$ 682,22/MWh para R$ 944,55/MWh

Desde o dia 01/01/2020, o despacho por ordem de mérito é indicado diariamente pelos resultados do modelo DESSEM. Assim, o despacho por ordem de mérito semanal, conforme publicado nesse documento, tem caráter apenas informativo. Da mesma forma, desde o dia 01/01/2021, a formação de preço deixou o formato semanal/patamar de carga e passou a ser horário, de acordo também com os resultados do modelo DESSEM.

2. NOTÍCIAS

Nos dias 29 e 30 de julho será realizada a reunião de elaboração do PMO de Agosto de 2021, com transmissão ao vivo através do site do ONS.

Como medida adicional de prevenção ao Coronavírus, o ONS informa que está suspensa, temporariamente, a participação presencial nas reuniões.

O conteúdo desta publicação foi produzido pelo ONS com base em dados e informações de conhecimento público. É de responsabilidade exclusiva dos agentes e demais interessados a obtenção de outros dados e informações, a realização de análises, estudos e avaliações para fins de tomada de decisões, definição de estratégias de atuação, assunção de compromissos e obrigações e quaisquer outras finalidades, em qualquer tempo e sob qualquer condição. É proibida a reprodução ou utilização total ou parcial do presente sem a identificação da fonte.

3. INFORMAÇÕES PARA ESTUDOS ENERGÉTICOS DE MÉDIO PRAZO - CONSTRUÇÃO DA FUNÇÃO DE CUSTO FUTURO

A atualização de dados para os estudos energéticos de médio prazo é realizada mensalmente quando da elaboração do PMO, tendo por base as informações fornecidas pela ANEEL, MME, EPE, CCEE e Agentes, além de diversas áreas do ONS.

3.1. ATUALIZAÇÃO DAS INFORMAÇÕES ESTRUTURAIS

3.1.1. Oferta

Nas Figura 1, Figura 2 e Figura 3, a seguir, são apresentadas as evoluções da oferta hidroelétrica, termoelétrica e da disponibilidade das usinas não simuladas individualmente, respectivamente, em comparação ao PMO de junho/2021, identificando eventuais atrasos ou antecipações de cronograma feitos na reunião de acompanhamento do Departamento de Monitoramento do Setor Elétrico – DMSE/MME, realizada em 17/06/2021.

Figura 1 - Evolução da potência instalada das UHEs

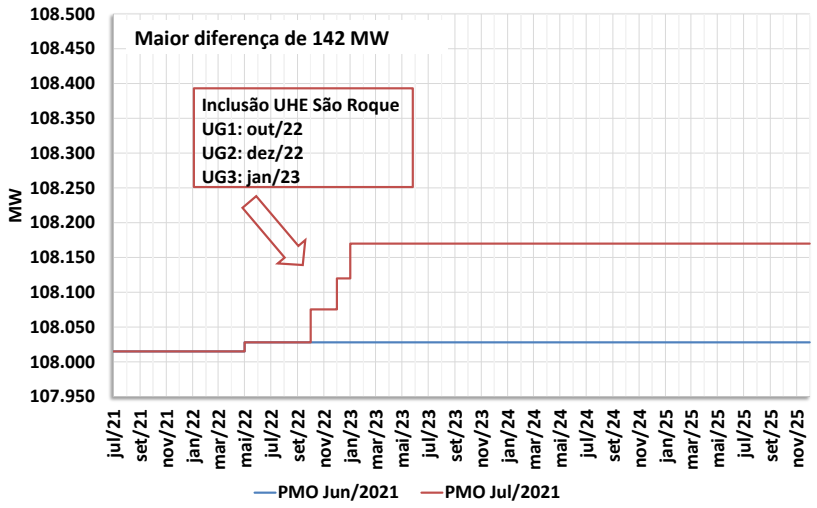

Figura 2 - Evolução da potência instalada das UTEs

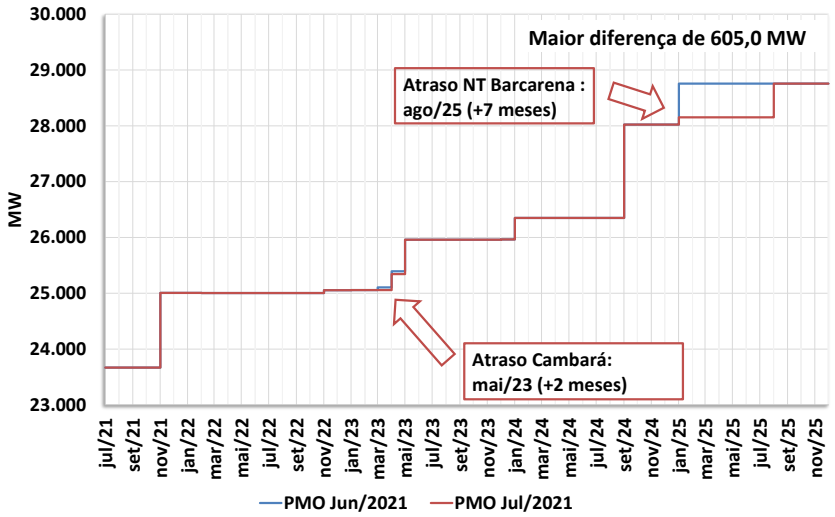

O conteúdo desta publicação foi produzido pelo ONS com base em dados e informações de conhecimento público. É de responsabilidade exclusiva dos agentes e demais interessados a obtenção de outros dados e informações, a realização de análises, estudos e avaliações para fins de tomada de decisões, definição de estratégias de atuação, assunção de compromissos e obrigações e quaisquer outras finalidades, em qualquer tempo e sob qualquer condição. É proibida a reprodução ou utilização total ou parcial do presente sem a identificação da fonte.

Figura 3 - Evolução da disponibilidade das usinas não simuladas

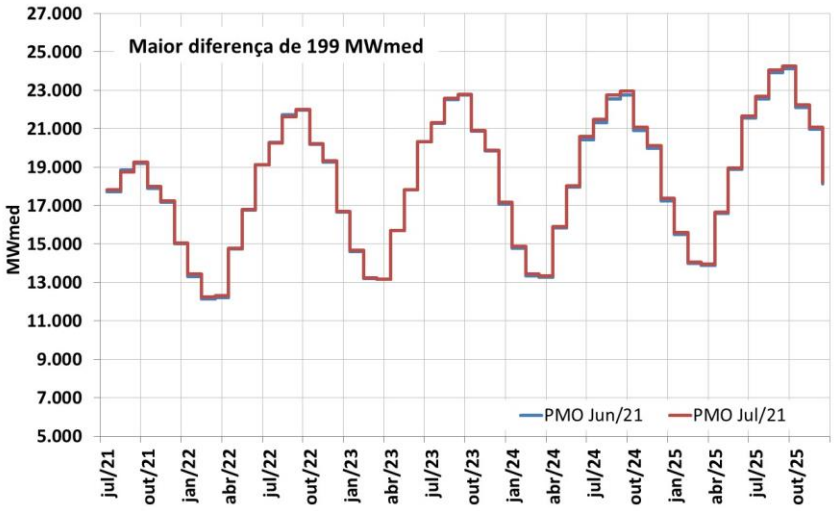

3.1.2. Armazenamentos Iniciais

Na Figura 4, a seguir, são apresentados os armazenamentos iniciais equivalentes por subsistema, considerados nos modelos de otimização para a elaboração do PMO de julho/2021, comparados com os do PMO de Junho/2021.

Figura 4 - Energia armazenada inicial em junho/21 e julho/21 – [% EARmáx]

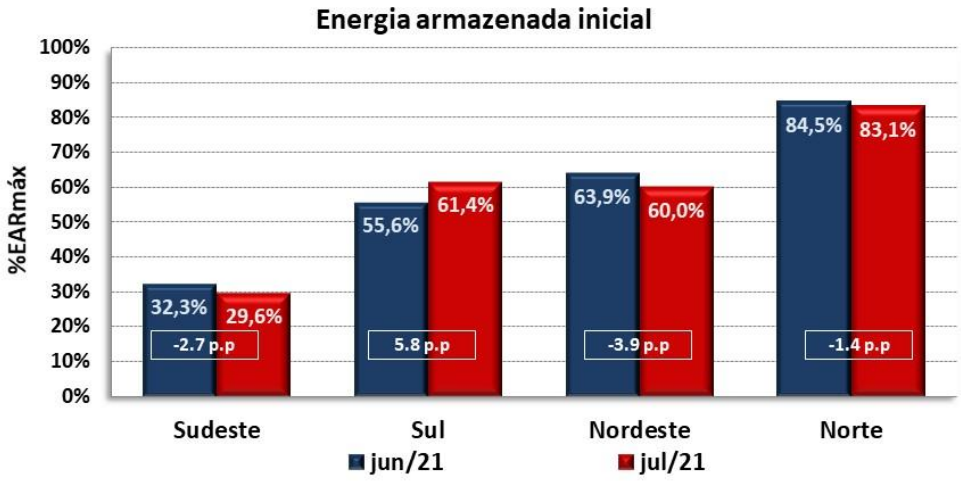

3.1.3. Tendência Hidrológica

Na Tabela 1, a seguir, são apresentadas as tendências hidrológicas consideradas pelo modelo NEWAVE para o PMO de Julho/2021, comparadas com o PMO de Junho/2021.

O conteúdo desta publicação foi produzido pelo ONS com base em dados e informações de conhecimento público. É de responsabilidade exclusiva dos agentes e demais interessados a obtenção de outros dados e informações, a realização de análises, estudos e avaliações para fins de tomada de decisões, definição de estratégias de atuação, assunção de compromissos e obrigações e quaisquer outras finalidades, em qualquer tempo e sob qualquer condição. É proibida a reprodução ou utilização total ou parcial do presente sem a identificação da fonte.

Tabela 1 – Tendência hidrológica para o PMO de Julho/2021 – NEWAVE [%MLT]

	PMO junho/2021				PMO julho/2021			
MÊS	SE/CO	S	NE	N	SE/CO	S	NE	N
dez/20	64	94	47	54				
jan/21	70	154	47	54	70	154	47	54
fev/21	73	122	42	71	73	122	42	70
mar/21	75	69	70	110	75	69	70	109
abr/21	64	35	35	88	64	35	35	87
mai/21	63	25	37	88	64	29	37	86
junho/21					67	58	38	72

* ≥100% MLT < 100% MLT

3.2. DEMAIS ATUALIZAÇÕES

Adicionalmente, neste PMO ocorreram os seguintes destaques:

- Horizonte de estudo: julho de 2021 a dezembro de 2025;
- Cronograma de Obras – Reunião DMSE-G de 17/06/2021, com destaque para a inclusão da UHE São Roque (141,9 MW) na oferta hidráulica em expansão;
- CVU de UTEs vendedoras em leilão;
- CVU das UTEs NorteFluminense 1, 2, 3, 4 e Termopernambuco, conforme Despachos SRG/ANEEL nº 1.876/2021 e 1.877/2021;
- Alterações de restrições operativas para as UHEs Pedra do Cavalo, Caconde, A.S. Oliveira, Funil Grande, Furnas, P. Primavera, Jupiá, M. de Moraes, P. Estrela, A.A. Laydner, Chavantes, Ilha Solteira e Três Irmãos, de acordo com os FSAR-H enviados pelos Agentes responsáveis;
- Atualização das disponibilidades de geração térmica das usinas existentes, no período julho a dezembro/21, informadas pelos agentes para todas as semanas operativas em resposta à Carta ONS 1.002/2021. Compatibilização da disponibilidade térmica para os dois primeiros meses de acordo com informação da programação mensal segundo Procedimentos de Rede do ONS (Submódulo 4.3 – Programação mensal da operação energética);
- Compatibilização dos valores da geração hidráulica mínima da UHE Itaipu dos dois primeiros meses com os utilizados na programação mensal;
- Restrições de defluências das usinas do Rio São Francisco conforme “Informe Sobre o Planejamento e a Programação da Operação dos Aproveitamentos Hidroelétricos da Bacia do Rio São Francisco no PMO de Julho de 2021”.

O conteúdo desta publicação foi produzido pelo ONS com base em dados e informações de conhecimento público. É de responsabilidade exclusiva dos agentes e demais interessados a obtenção de outros dados e informações, a realização de análises, estudos e avaliações para fins de tomada de decisões, definição de estratégias de atuação, assunção de compromissos e obrigações e quaisquer outras finalidades, em qualquer tempo e sob qualquer condição. É proibida a reprodução ou utilização total ou parcial do presente sem a identificação da fonte.

4. ANÁLISE DAS CONDIÇÕES HIDROMETEOROLÓGICAS

As bacias hidrográficas da região Sul apresentam totais significativos de precipitação devido ao avanço de uma nova frente fria no início da semana operativa com destaque para as bacias dos rios Jacuí, Uruguai, Iguaçu e o trecho incremental a UHE Itaipu (Figura 5). Na região Norte, continua o padrão da semana operativa anterior, com pancadas de chuva isoladas nos trechos mais baixos dessas bacias.

Figura 5 - Precipitação acumulada prevista pelo modelo ECMWF (ECMWF) para o período de 24/06/2021 a 01/07/2021.

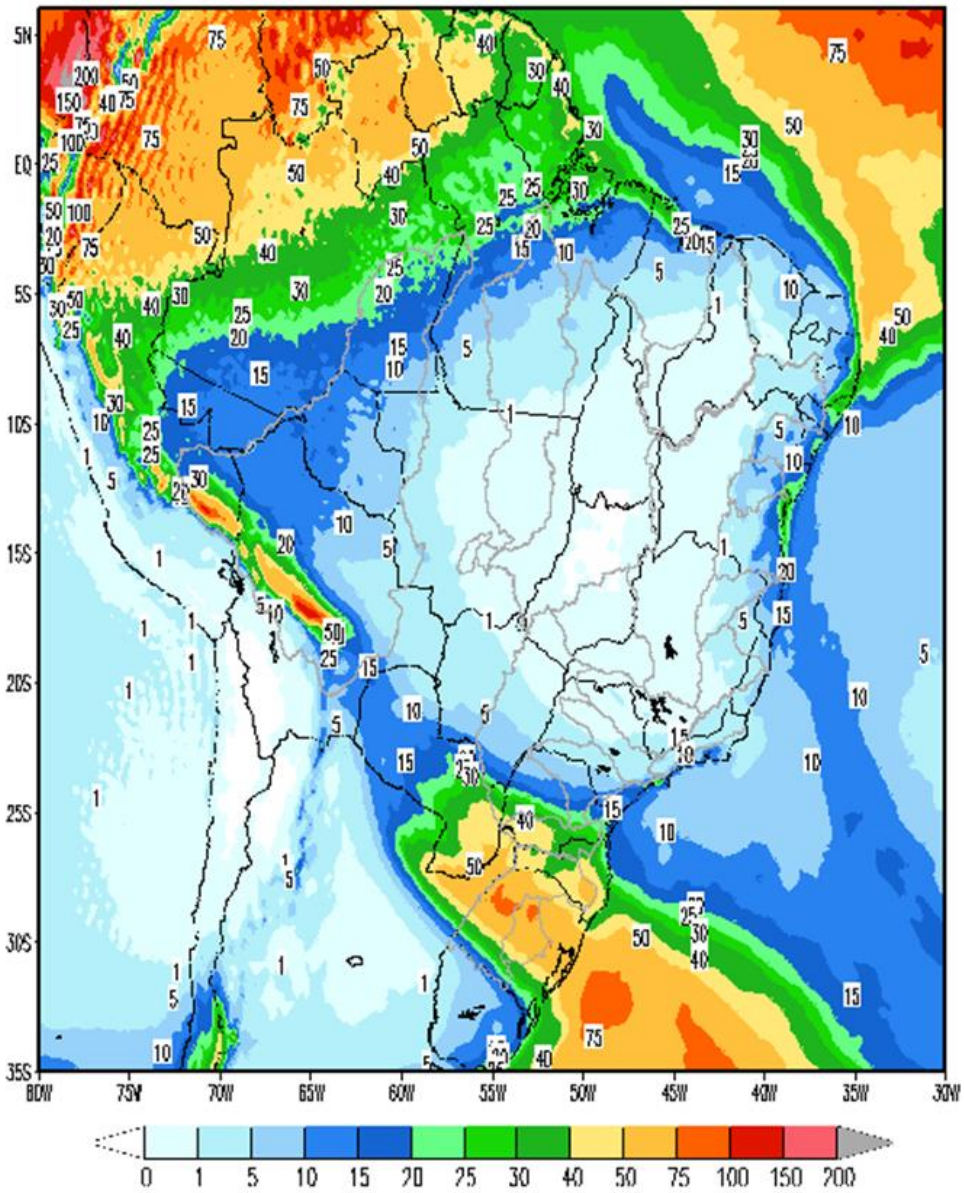

Em comparação com os valores estimados para a semana em curso, prevê-se para a próxima semana operativa ascensão nas afluências do subsistema sul e recessão nas afluências dos subsistemas sudeste, nordeste e norte. A previsão mensal para julho indica a ocorrência de afluências abaixo da média histórica para todos os subsistemas.

O conteúdo desta publicação foi produzido pelo ONS com base em dados e informações de conhecimento público. É de responsabilidade exclusiva dos agentes e demais interessados a obtenção de outros dados e informações, a realização de análises, estudos e avaliações para fins de tomada de decisões, definição de estratégias de atuação, assunção de compromissos e obrigações e quaisquer outras finalidades, em qualquer tempo e sob qualquer condição. É proibida a reprodução ou utilização total ou parcial do presente sem a identificação da fonte.

Tabela 2 – Previsão de ENAs do PMO de Julho/2021

PMO de Julho/2021 - ENAs previstas				
Subsistema	26/06 a 02/07/2021		Mês de julho	
	MWmed	%MLT	MWmed	%MLT
SE/CO	18.128	59	16.132	63
S	9.557	90	5.788	53
NE	1.704	39	1.627	43
N	5.545	61	4.217	80

5. PREVISÃO DE CARGA

A expectativa de que o setor industrial se mantenha em patamares elevados principalmente daquelas indústrias voltadas para exportação, e a melhora dos setores comercial e serviços em função do avanço da campanha de vacinação, conforme os indicadores de confiança disponibilizados pela FGV em maio/21, estão se refletindo nas projeções de carga realizadas para o mês de julho/21.

As previsões meteorológicas indicam para a próxima semana operativa temperaturas semelhantes às observadas na semana em curso para todas as regiões do Brasil, com exceção de Porto Alegre onde existe a sinalização de redução das temperaturas médias. Dessa forma, destaca-se a previsão de ocorrência de temperaturas amenas nas regiões SE/CO e SUL e nas regiões Nordeste e Norte ressalta-se a expectativa de totais de precipitação similares a semana atual.

As taxas de crescimento previstas para o mês de julho em relação ao mesmo mês do ano anterior, são de 4,0% para os subsistemas Sudeste/Centro-Oeste, 3,5% para o subsistema Sul, 7,1% no Nordeste e 7,9% no subsistema do Norte.

Tabela 3 – Evolução da carga do PMO de julho 2021

Subsistema	CARGA SEMANAL (MWmed)						CARGA MENSAL (MWmed)	
	1ª Sem	2ª Sem	3ª Sem	4ª Sem	5ª Sem	6ª Sem	jul/21	Var. (%) jul/21 -> jul/20
SE/CO	37.806	37.837	38.127	38.256	38.329	38.398	38.124	4,0%
Sul	11.499	11.476	11.481	11.489	11.492	11.502	11.486	3,5%
Nordeste	10.994	10.808	10.747	10.757	10.766	10.770	10.784	7,1%
Norte	5.980	5.877	5.879	5.889	5.895	5.907	5.892	7,9%
SIN	**66.279**	**65.998**	**66.234**	**66.391**	**66.482**	**66.577**	**66.286**	**4,7%**

O conteúdo desta publicação foi produzido pelo ONS com base em dados e informações de conhecimento público. É de responsabilidade exclusiva dos agentes e demais interessados a obtenção de outros dados e informações, a realização de análises, estudos e avaliações para fins de tomada de decisões, definição de estratégias de atuação, assunção de compromissos e obrigações e quaisquer outras finalidades, em qualquer tempo e sob qualquer condição. É proibida a reprodução ou utilização total ou parcial do presente sem a identificação da fonte.

6. PRINCIPAIS RESULTADOS

6.1. CUSTO MARGINAL DE OPERAÇÃO (CMO)

A tabela a seguir apresenta o CMO, por subsistema e patamar de carga para próxima semana operativa.

Tabela 4 – CMO por patamar de carga

Patamares de Carga	CMO (R$/MWh)			
	SE/CO	S	NE	N
Pesada	958,41	958,41	958,41	958,41
Média	951,45	951,45	951,45	951,45
Leve	930,43	930,43	930,43	930,43
Média Semanal	944,55	944,55	944,55	944,55

Na figura a seguir é apresentada a evolução do CMO médio semanal ao longo deste PMO.

Figura 6 – Evolução semanal do CMO

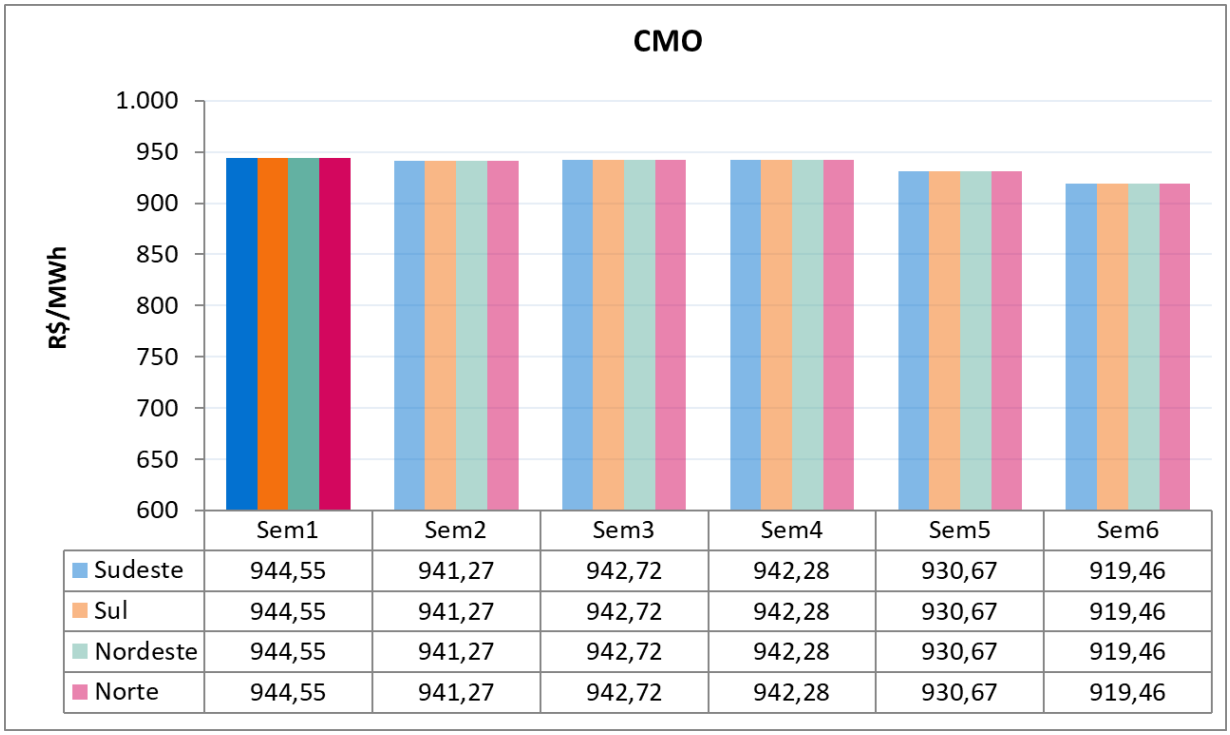

	Sem1	Sem2	Sem3	Sem4	Sem5	Sem6
Sudeste	944,55	941,27	942,72	942,28	930,67	919,46
Sul	944,55	941,27	942,72	942,28	930,67	919,46
Nordeste	944,55	941,27	942,72	942,28	930,67	919,46
Norte	944,55	941,27	942,72	942,28	930,67	919,46

6.2. POLÍTICA DE OPERAÇÃO ENERGÉTICA

Para esta semana operativa, está prevista a seguinte política de intercâmbio de energia entre regiões:

Região SE/CO → Geração minimizada de acordo com os condicionantes hidráulicos.

Região Sul → Geração dimensionada para fechamento do balanço energético do SIN.

Região NE → Aumento da geração eólica e exportação de energia, modulando em função de seus recursos energéticos, respeitando-se os limites elétricos vigentes.

Região Norte → Redução da exploração das disponibilidades energéticas, respeitando-se os limites elétricos vigentes.

O conteúdo desta publicação foi produzido pelo ONS com base em dados e informações de conhecimento público. É de responsabilidade exclusiva dos agentes e demais interessados a obtenção de outros dados e informações, a realização de análises, estudos e avaliações para fins de tomada de decisões, definição de estratégias de atuação, assunção de compromissos e obrigações e quaisquer outras finalidades, em qualquer tempo e sob qualquer condição. É proibida a reprodução ou utilização total ou parcial do presente sem a identificação da fonte.

7. GERAÇÃO TÉRMICA

A Figura 7 apresenta, para cada subsistema, o despacho térmico por modalidade indicado pelo DECOMP para a próxima semana operativa.

Figura 7 – Geração térmica para a próxima semana operativa

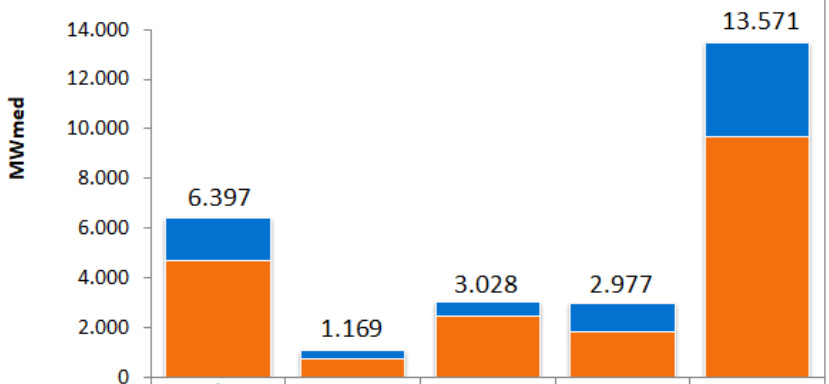

	SE/CO	SUL	NE	NORTE	SIN
RESTRIÇÃO ELÉTRICA	0	0	0	0	0
INFLEXIBILIDADE	1735	334	565	1148	3782
ORDEM DE MÉRITO	4662	738	2463	1829	9692

Na tabela abaixo segue a Indicação de despacho antecipado por ordem de mérito de custo para a semana de 28/08 a 03/09/2021.

Tabela 5 – UTEs com contrato de combustível GNL

UTE			Benefício (R$/MWh)		
Nome	Cod	CVU (R$/MWh)	Carga Pesada	Carga Média	Carga Leve
SANTA CRUZ	86	199,25	823,42 (1)	823,42 (1)	821,87 (1)
LUIZORMELO	15	303,14	823,42 (1)	823,42 (1)	821,87 (1)
PSERGIPE I	224	304,16	333,98 (1)	333,98 (1)	333,97 (1)

(1) Comandado o despacho antecipado por ordem de mérito de custo nesse patamar

(2) NÃO foi comandado o despacho antecipado por ordem de mérito de custo nesse patamar

Assim sendo, há previsão de despacho antecipado por ordem de mérito de custo para as UTE Santa Cruz, Luiz O. R. Melo e Porto Sergipe I, para a semana de 28/08 a 03/09/2021.

Ressalta-se que, conforme declaração do agente, a UTE Luiz O. R. Melo tem parada programada para o período entre 15/08 e 13/09/2021.

O conteúdo desta publicação foi produzido pelo ONS com base em dados e informações de conhecimento público. É de responsabilidade exclusiva dos agentes e demais interessados a obtenção de outros dados e informações, a realização de análises, estudos e avaliações para fins de tomada de decisões, definição de estratégias de atuação, assunção de compromissos e obrigações e quaisquer outras finalidades, em qualquer tempo e sob qualquer condição. É proibida a reprodução ou utilização total ou parcial do presente sem a identificação da fonte.

8. IMPORTAÇÃO DE ENERGIA DA REPÚBLICA ORIENTAL DO URUGUAI

8.1. República Oriental do Uruguai

Para a próxima semana operativa, foram declaradas as seguintes ofertas de importação de energia da República Oriental do Uruguai para o Sistema Interligado Nacional - SIN através das conversoras de Rivera (70 MW) e Melo (500 MW).

- **Eletrobras**

Tabela 6 – Energia ofertada para importação

	Oferta de Energia para a Semana de 26/06 a 02/07 (MWmed)			
	Bloco 1	Bloco 2	Bloco 3	Total
Carga Pesada	70	90	135	295
Carga Média	70	90	135	295
Carga Leve	70	90	135	295
CVU (R$/MWh)	772,32	1.051,65	1.205,26	

- **Enel**

Conforme declaração do agente, esta importação poderá ser realizada exclusivamente pela conversora Melo.

Tabela 7 – Energia ofertada para importação

	Oferta de Energia para a Semana de 26/06 a 02/07 (MWmed)			
	Bloco 1	Bloco 2	Bloco 3	Total
Carga Pesada	50	90	135	275
Carga Média	50	90	135	275
Carga Leve	50	90	135	275
CVU (R$/MWh)	790,91	1.073,27	1.231,57	

8.2. República da Argentina

- **Enel**

Para esta semana operativa, não houve oferta de importação de energia da República da Argentina.

Nota: Detalhes sobre a importação de energia vide Portaria Nº 339, de 15 de agosto de 2018 disponível em: http://pesquisa.in.gov.br/imprensa/jsp/visualiza/index.jsp?data=17/08/2018&jornal=515&pagina=60&totalArquivos=136

O conteúdo desta publicação foi produzido pelo ONS com base em dados e informações de conhecimento público. É de responsabilidade exclusiva dos agentes e demais interessados a obtenção de outros dados e informações, a realização de análises, estudos e avaliações para fins de tomada de decisões, definição de estratégias de atuação, assunção de compromissos e obrigações e quaisquer outras finalidades, em qualquer tempo e sob qualquer condição. É proibida a reprodução ou utilização total ou parcial do presente sem a identificação da fonte.

9. ARMAZENAMENTOS OPERATIVOS

Para uma melhor avaliação de diversos cenários hidrometeorológicos, notadamente, aqueles de curto prazo e suas influências nas previsões de vazões nos subsistemas, os resultados deste PMO contemplam cenários de afluências visando melhor representar a ocorrência de precipitação e, consequentemente, seus efeitos sobre as afluências e armazenamentos.

Além dos resultados associados ao valor esperado das previsões de afluências, as simulações operativas também foram realizadas com os limites superior e inferior das previsões de afluências. Apresentamos a seguir os resultados obtidos com a aplicação dos diferentes cenários de afluência.

Tabela 8 – Previsão de ENA dos cenários de sensibilidade

Subsistema	ENERGIAS NATURAIS AFLUENTES					
	Previsão Mensal					
	LI		VE		LS	
	(MWmed)	%MLT	(MWmed)	%MLT	(MWmed)	%MLT
SE/CO	14.192	**55**	16.132	**63**	18.069	**70**
Sul	2.969	**27**	5.788	**53**	9.485	**87**
Nordeste	1.505	**40**	1.627	**43**	1.749	**46**
Norte	3.824	**72**	4.217	**80**	4.610	**87**

Tabela 9 – Previsão de %EARmáx para o final do mês

Subsistema	% EARmáx 25/06	% EARmáx - 31/07		
	NÍVEL INICIAL	NÍVEL PMO		
	VE	LI	VE	LS
SE/CO	29,5	25,4	26,6	27,4
Sul	61,4	36,6	42,6	49,6
Nordeste	60,0	53,3	53,6	53,8
Norte	83,1	79,6	80,2	80,5

O conteúdo desta publicação foi produzido pelo ONS com base em dados e informações de conhecimento público. É de responsabilidade exclusiva dos agentes e demais interessados a obtenção de outros dados e informações, a realização de análises, estudos e avaliações para fins de tomada de decisões, definição de estratégias de atuação, assunção de compromissos e obrigações e quaisquer outras finalidades, em qualquer tempo e sob qualquer condição. É proibida a reprodução ou utilização total ou parcial do presente sem a identificação da fonte.

10. RESERVATÓRIOS EQUIVALENTES DE ENERGIA

A seguir são apresentadas as previsões de Energia Natural Afluente para a próxima semana operativa e para o mês de julho, bem como as previsões de Energia Armazenada nos Reservatórios Equivalentes de Energia – REE, deste PMO.

Tabela 10 – Previsão de ENA por REE

Valor Esperado das Energias Naturais Afluentes				
REE	Previsão Semanal		Previsão Mensal	
	26/06/2021 a 02/07/2021		jul-21	
	(MWmed)	%MLT	(MWmed)	%MLT
Sudeste	2.030	61	1.895	65
Madeira	4.672	86	3.673	95
Teles Pires	930	74	822	84
Itaipu	2.135	61	1.989	64
Paraná	7.077	48	6.614	53
Paranapanema	1.125	45	1.064	47
Sul	7.511	138	3.990	67
Iguaçu	2.046	40	1.751	35
Nordeste	1.704	39	1.628	43
Norte	2.213	57	1.807	70
Belo Monte	2.004	52	1.210	75
Manaus	1.729	126	1.382	130

Tabela 11 – Previsão de %EARmáx por REE

% Energia Armazenável Máxima		
REE	Previsão Semanal	Previsão Mensal
	02-jul	31-jul
	(%EARmáx)	(%EARmáx)
Sudeste	38,4	34,5
Madeira	85,8	75,9
Teles Pires	65,8	57,9
Itaipu	20,6	84,2
Paraná	24,3	22,0
Paranapanema	40,2	41,6
Sul	62,6	47,6
Iguaçu	62,2	39,3
Nordeste	58,6	53,7
Norte	82,5	80,2
Belo Monte	100,0	99,1
Manaus	92,5	82,5

O conteúdo desta publicação foi produzido pelo ONS com base em dados e informações de conhecimento público. É de responsabilidade exclusiva dos agentes e demais interessados a obtenção de outros dados e informações, a realização de análises, estudos e avaliações para fins de tomada de decisões, definição de estratégias de atuação, assunção de compromissos e obrigações e quaisquer outras finalidades, em qualquer tempo e sob qualquer condição. É proibida a reprodução ou utilização total ou parcial do presente sem a identificação da fonte.

11. DESPACHO TÉRMICO POR MODALIDADE, PATAMAR DE CARGA E USINA

Nas tabelas abaixo, a diferenciação entre geração por inflexibilidade e por ordem de mérito tem caráter informativo, com o objetivo de detalhar a informação de inflexibilidade enviada pelos respectivos agentes para o PMO. Ressalta-se que nas etapas de Programação Diária e Tempo Real, o montante despachado nas usinas termelétricas indicadas por ordem de mérito é plenamente intitulado como ordem de mérito.

REGIÃO SUDESTE/CENTRO-OESTE

Térmicas Potência (MW)	Combustível	CVU (R$/MWh)	Inflexibilidade			Ordem de Mérito			Total Mérito e INFL.			Razão Elétrica			Total UTE		
			P	M	L	P	M	L	P	M	L	P	M	L	P	M	L
ATLAN_CSA (255)	Resíduos	0,00	157,0	157,0	157,0				157,0	157,0	157,0				157,0	157,0	157,0
ANGRA 2 (1350)	Nuclear	20,12				0,0	0,0	0,0	0,0	0,0	0,0				0,0	0,0	0,0
ANGRA 1 (640)	Nuclear	31,17	640,0	640,0	640,0	0,0	0,0	0,0	640,0	640,0	640,0				640,0	640,0	640,0
NORTEFLU 1 (400)	Gás	82,94	400,0	400,0	400,0	0,0	0,0	0,0	400,0	400,0	400,0				400,0	400,0	400,0
NORTEFLU 2 (100)	Gás	95,16	100,0	100,0	100,0	0,0	0,0	0,0	100,0	100,0	100,0				100,0	100,0	100,0
O.PINTADA (50)	Biomassa	112,47	5,0	5,0	5,0	45,0	45,0	45,0	50,0	50,0	50,0				50,0	50,0	50,0
UTE STA VI (41)	Biomassa	121,49	13,0	13,0	13,0	28,4	28,4	28,4	41,4	41,4	41,4				41,4	41,4	41,4
PREDILECTA (5)	Biomassa	158,95	1,0	1,0	1,0	4,0	4,0	4,0	5,0	5,0	5,0				5,0	5,0	5,0
NORTEFLU 3 (200)	Gás	180,48	200,0	200,0	200,0	0,0	0,0	0,0	200,0	200,0	200,0				200,0	200,0	200,0
BAIXADA FL (530)	Gás	196,19				530,0	530,0	530,0	530,0	530,0	530,0				530,0	530,0	530,0
SANTA CRUZ (500)	GNL	199,25				350,0	350,0	350,0	350,0	350,0	350,0				350,0	350,0	350,0
ATLANTICO (235)	Resíduos	202,37	218,7	218,7	218,7	0,0	0,0	0,0	218,7	218,7	218,7				218,7	218,7	218,7
T.LAGOAS (350)	Gás	262,50				270,0	270,0	270,0	270,0	270,0	270,0				270,0	270,0	270,0
JUIZ DE FO (87)	Gás	283,74				84,8	84,8	84,8	84,8	84,8	84,8				84,8	84,8	84,8
LUIZORMELO (204)	GNL	303,14															
ST.CRUZ 34 (436)	Óleo	310,41															
TERMORIO (1036)	Gás	329,49				820,0	820,0	820,0	820,0	820,0	820,0				820,0	820,0	820,0
CUBATAO (216)	Gás	350,13				209,0	209,0	209,0	209,0	209,0	209,0				209,0	209,0	209,0
SEROPEDICA (386)	Gás	410,56				295,7	295,7	295,7	295,7	295,7	295,7				295,7	295,7	295,7
PIRAT.12 O (200)	Gás	470,34															
NPIRATINGA (572)	Gás	548,04				265,0	265,0	265,0	265,0	265,0	265,0				265,0	265,0	265,0
IBIRITE (226)	Gás	573,90				222,0	222,0	222,0	222,0	222,0	222,0				222,0	222,0	222,0
NORTEFLU 4 (127)	Gás	600,80				126,0	126,0	126,0	126,0	126,0	126,0				126,0	126,0	126,0
CUIABA CC (529)	Gás	675,63				490,0	490,0	490,0	490,0	490,0	490,0				490,0	490,0	490,0
T.MACAE (929)	Gás	738,49				825,8	825,8	825,8	825,8	825,8	825,8				825,8	825,8	825,8
PALMEIR_GO (176)	Diesel	762,95				0,0	0,0	0,0	0,0	0,0	0,0				0,0	0,0	0,0
TNORTE 2 (340)	Óleo	910,86															
VIANA (175)	Óleo	930,45				174,6	174,6		174,6	174,6					174,6	174,6	0,0
CAMPOS (25)	Gás	978,10															
DAIA (44)	Diesel	1019,32															
GOIANIA 2 (140)	Diesel	1066,14															
XAVANTES (54)	Diesel	1464,89															
TOTAL SE/CO (10558)			1734,7	1734,7	1734,7	4740,3	4740,3	4565,7	6475,0	6475,0	6300,4	0,0	0,0	0,0	6475,0	6475,0	6300,4

REGIÃO SUL

Térmicas Potência (MW)	Combustível	CVU (R$/MWh)	Inflexibilidade			Ordem de Mérito			Total Mérito e INFL.			Razão Elétrica			Total UTE		
			P	M	L	P	M	L	P	M	L	P	M	L	P	M	L
URUGUAIANA (640)	Gás	0,00															
PAMPA SUL (345)	Carvão	69,75				0,0	0,0	0,0									
SAO SEPE (8)	Biomassa	87,75	7,0	7,0	7,0	0,0	0,0	0,0	7,0	7,0	7,0				7,0	7,0	7,0
CANDIOTA_3 (350)	Carvão	90,73	325,0	325,0	325,0	0,0	0,0	0,0	325,0	325,0	325,0				325,0	325,0	325,0
J.LACER. C (363)	Carvão	206,84				0,0	0,0	0,0	0,0	0,0	0,0				0,0	0,0	0,0
J.LACER. B (262)	Carvão	244,14				262,0	262,0	262,0	262,0	262,0	262,0				262,0	262,0	262,0
J.LAC. A2 (132)	Carvão	245,21				132,0	132,0	132,0	132,0	132,0	132,0				132,0	132,0	132,0
J.LAC. A1 (100)	Carvão	270,48				100,0	100,0	100,0	100,0	100,0	100,0				100,0	100,0	100,0
MADEIRA (4)	Biomassa	321,94	2,0	2,0	2,0	1,0	1,0	1,0	3,0	3,0	3,0				3,0	3,0	3,0
FIGUEIRA (20)	Carvão	475,68				0,0	0,0	0,0	0,0	0,0	0,0				0,0	0,0	0,0
CANOAS (249)	Diesel	698,14				243,1	243,1	243,1	243,1	243,1	243,1				243,1	243,1	243,1
ARAUCARIA (484)	Gás	934,91				192,0	145,5		192,0	145,5					192,0	145,5	0,0
TOTAL SUL (2957)			334,0	334,0	334,0	930,1	883,6	738,1	1264,1	1217,6	1072,1	0,0	0,0	0,0	1264,1	1217,6	1072,1

O conteúdo desta publicação foi produzido pelo ONS com base em dados e informações de conhecimento público. É de responsabilidade exclusiva dos agentes e demais interessados a obtenção de outros dados e informações, a realização de análises, estudos e avaliações para fins de tomada de decisões, definição de estratégias de atuação, assunção de compromissos e obrigações e quaisquer outras finalidades, em qualquer tempo e sob qualquer condição. É proibida a reprodução ou utilização total ou parcial do presente sem a identificação da fonte.

REGIÃO NORDESTE

Térmicas Potência (MW)	Combustível	CVU (R$/MWh)	Inflexibilidade			Ordem de Mérito			Total Mérito e INFL.			Razão Elétrica			Total UTE		
			P	M	L	P	M	L	P	M	L	P	M	L	P	M	L
ALTOS (13)	Diesel	0,00															
ARACATI (11)	Diesel	0,00															
BATURITE (11)	Diesel	0,00															
C.MAIOR (13)	Diesel	0,00															
CAUCAIA (15)	Diesel	0,00															
CRATO (13)	Diesel	0,00															
IGUATU (15)	Diesel	0,00															
JUAZEIRO N (15)	Diesel	0,00															
MARAMBAIA (13)	Diesel	0,00															
NAZARIA (13)	Diesel	0,00															
PECEM (15)	Diesel	0,00															
ERB CANDEI (17)	Biomassa	87,81	4,5	4,5	4,5	6,5	6,5	6,5	11,0	11,0	11,0				11,0	11,0	11,0
PROSPERIDA (28)	Gás	165,61	28,0	28,0	28,0	0,0	0,0	0,0	28,0	28,0	28,0				28,0	28,0	28,0
TERMOPE (533)	Gás	173,38	532,7	532,7	532,7	0,0	0,0	0,0	532,7	532,7	532,7				532,7	532,7	532,7
FORTALEZA (327)	Gás	245,46				326,6	326,6	326,6	326,6	326,6	326,6				326,6	326,6	326,6
P.PECEM1 (720)	Carvão	265,17				720,0	720,0	720,0	720,0	720,0	720,0				720,0	720,0	720,0
P.PECEM2 (365)	Carvão	271,10				365,0	365,0	365,0	365,0	365,0	365,0				365,0	365,0	365,0
PSERGIPE I (1516)	GNL	304,16															
TERMOCEARA (223)	Gás	431,13				0,0	0,0	0,0									
SYKUE I (30)	Biomassa	510,12				0,0	0,0	0,0									
VALE ACU (368)	Gás	618,70				110,0	110,0	110,0	110,0	110,0	110,0				110,0	110,0	110,0
T.BAHIA (186)	Gás	633,56				158,9	158,9	158,9	158,9	158,9	158,9				158,9	158,9	158,9
PERNAMBU_3 (201)	Óleo	802,20				0,0	0,0	0,0									
BAHIA_1 (31)	Óleo	818,43				27,0	27,0	27,0	27,0	27,0	27,0				27,0	27,0	27,0
MARACANAU (168)	Óleo	905,02				109,0	106,6	104,7	109,0	106,6	104,7				109,0	106,6	104,7
TERMOCABO (50)	Óleo	919,04				49,7	49,7	49,7	49,7	49,7	49,7				49,7	49,7	49,7
TERMONE (171)	Óleo	922,48				162,0	162,0	162,0	162,0	162,0	162,0				162,0	162,0	162,0
TERMOPB (171)	Óleo	922,48				162,0	162,0	162,0	162,0	162,0	162,0				162,0	162,0	162,0
CAMPINA_GR (169)	Óleo	930,47				118,0	118,0		118,0	118,0					118,0	118,0	0,0
SUAPE II (381)	Óleo	951,30				367,4	365,5		367,4	365,5					367,4	365,5	0,0
POTIGUAR_3 (66)	Diesel	1002,56															
POTIGUAR (53)	Diesel	1002,57															
AREMBEPE (150)	Óleo	1021,36															
MURICY (147)	Óleo	1021,36															
GLOBAL I (149)	Óleo	1054,22															
GLOBAL II (149)	Óleo	1054,22															
PETROLINA (136)	Óleo	1120,20															
PAU FERRO (94)	Diesel	1135,00															
TERMOMANAU (143)	Diesel	1135,00															
TOTAL NE (6889)			565,2	565,2	565,2	2682,1	2677,8	2192,4	3247,3	3243,0	2757,6	0,0	0,0	0,0	3247,3	3243,0	2757,6

REGIÃO NORTE

Térmicas Potência (MW)	Combustível	CVU (R$/MWh)	Inflexibilidade			Ordem de Mérito			Total Mérito e INFL.			Razão Elétrica			Total UTE		
			P	M	L	P	M	L	P	M	L	P	M	L	P	M	L
C. ROCHA (85)	Gás	0,00	65,0	65,0	65,0				65,0	65,0	65,0				65,0	65,0	65,0
JARAQUI (75)	Gás	0,00	63,0	63,0	63,0				63,0	63,0	63,0				63,0	63,0	63,0
MANAUARA (67)	Gás	0,00	64,5	64,5	64,5				64,5	64,5	64,5				64,5	64,5	64,5
PONTA NEGR (66)	Gás	0,00	64,0	64,0	64,0				64,0	64,0	64,0				64,0	64,0	64,0
TAMBAQUI (93)	Gás	0,00	63,0	63,0	63,0				63,0	63,0	63,0				63,0	63,0	63,0
MARANHAO3 (519)	Gás	85,72	490,0	490,0	490,0	4,8	25,3	22,7	494,8	515,3	512,7				494,8	515,3	512,7
APARECIDA (166)	Gás	96,11	75,0	75,0	75,0	76,6	74,6	72,1	151,6	149,6	147,1				151,6	149,6	147,1
UTE MAUA 3 (591)	Gás	96,11	264,0	264,0	264,0	326,8	231,2	66,0	590,8	495,2	330,0				590,8	495,2	330,0
PARNAIB_IV (56)	Gás	151,69				56,3	54,0	52,8	56,3	54,0	52,8				56,3	54,0	52,8
MARAN_VL_7 (336)	Gás	183,95				326,0	334,9	333,8	326,0	334,9	333,8				326,0	334,9	333,8
MARANIVL_7 (336)	Gás	183,95				325,9	334,9	333,7	325,9	334,9	333,7				325,9	334,9	333,7
MARAN_VL22 (1)	Gás	183,96				1,1	1,1	1,1	1,1	1,1	1,1				1,1	1,1	1,1
MARANIVL22 (1)	Gás	183,96				1,1	1,1	1,1	1,1	1,1	1,1				1,1	1,1	1,1
N.VEN2_L22 (27)	Gás	232,27				27,0	27,0	27,0	27,0	27,0	27,0				27,0	27,0	27,0
N.VEN2_L7 (151)	Gás	232,27				144,4	150,2	149,4	144,4	150,2	149,4				144,4	150,2	149,4
P. ITAQUI (360)	Carvão	264,93				360,1	360,1	360,1	360,1	360,1	360,1				360,1	360,1	360,1
GERAMAR1 (166)	Óleo	930,43				159,2	159,2	159,2	159,2	159,2	159,2				159,2	159,2	159,2
GERAMAR2 (166)	Óleo	930,43				159,2	159,2	101,1	159,2	159,2	101,1				159,2	159,2	101,1
TOTAL NORTE (3264)			1148,5	1148,5	1148,5	1968,5	1912,8	1680,1	3117,0	3061,3	2828,6	0,0	0,0	0,0	3117,0	3061,3	2828,6

O conteúdo desta publicação foi produzido pelo ONS com base em dados e informações de conhecimento público. É de responsabilidade exclusiva dos agentes e demais interessados a obtenção de outros dados e informações, a realização de análises, estudos e avaliações para fins de tomada de decisões, definição de estratégias de atuação, assunção de compromissos e obrigações e quaisquer outras finalidades, em qualquer tempo e sob qualquer condição. É proibida a reprodução ou utilização total ou parcial do presente sem a identificação da fonte.