## 1. APRESENTAÇÃO

No mês de julho os maiores totais de precipitação ficaram restritos ao extremo norte do país. O avanço de uma frente fria pelas regiões Sul, Sudeste e litoral da Bahia ocasionou chuva fraca nas bacias dos rios Jacuí, Uruguai, Iguaçu, no trecho de cabeceira do Tietê e em pontos isolados do Paranapanema e da incremental a UHE Itaipu.

Na semana de 31/07 a 06/08/2021, a precipitação fica restrita ao extremo norte do país, atingindo apenas o final da cascata do Xingu. Para as bacias hidrográficas de interesse do SIN não há previsão de precipitação significativa.

Para a semana operativa de 31/07 a 06/08/2021, houve oferta de energia da República Oriental do Uruguai e da República da Argentina. De acordo com o Art. 2º da Portaria MME nº 339, de 15 de agosto de 2018, as ofertas para importação de energia não foram consideradas na elaboração do PMO.

Os valores médios semanais do Custo Marginal de Operação – CMO dos subsistemas do SIN sofreram as seguintes alterações em relação à semana anterior:

- SE/CO: de R$ 1.239,00/MWh para R$ 2.540,18/MWh
- Sul: de R$ 1.239,00/MWh para R$ 2.540,18/MWh
- Nordeste: de R$ 1.239,00/MWh para R$ 2.540,18/MWh
- Norte: de R$ 1.239,00/MWh para R$ 2.540,18/MWh

Desde o dia 01/01/2020, o despacho por ordem de mérito é indicado diariamente pelos resultados do modelo DESSEM. Assim, o despacho por ordem de mérito semanal, conforme publicado nesse documento, tem caráter apenas informativo. Da mesma forma, desde o dia 01/01/2021, a formação de preço deixou o formato semanal/patamar de carga e passou a ser horário, de acordo também com os resultados do modelo DESSEM.

## 2. NOTÍCIAS

Nos dias 26 e 27 de agosto será realizada a reunião de elaboração do PMO de Setembro de 2021, com transmissão ao vivo através do site do ONS.

Como medida adicional de prevenção ao Coronavírus, o ONS informa que está suspensa, temporariamente, a participação presencial nas reuniões.

## 3. INFORMAÇÕES PARA ESTUDOS ENERGÉTICOS DE MÉDIO PRAZO - CONSTRUÇÃO DA FUNÇÃO DE CUSTO FUTURO

A atualização de dados para os estudos energéticos de médio prazo é realizada mensalmente quando da elaboração do PMO, tendo por base as informações fornecidas pela ANEEL, MME, EPE, CCEE e Agentes, além de diversas áreas do ONS.

O conteúdo desta publicação foi produzido pelo ONS com base em dados e informações de conhecimento público. É de responsabilidade exclusiva dos agentes e demais interessados a obtenção de outros dados e informações, a realização de análises, estudos e avaliações para fins de tomada de decisões, definição de estratégias de atuação, assunção de compromissos e obrigações e quaisquer outras finalidades, em qualquer tempo e sob qualquer condição. É proibida a reprodução ou utilização total ou parcial do presente sem a identificação da fonte.

## 3.1. ATUALIZAÇÃO DAS INFORMAÇÕES ESTRUTURAIS

### 3.1.1. Oferta

Nas **Figura 1**, **Figura 2** e **Figura 3,** a seguir, são apresentadas as evoluções da oferta hidroelétrica, termoelétrica e da disponibilidade das usinas não simuladas individualmente, respectivamente, em comparação ao PMO de julho/2021, identificando eventuais atrasos ou antecipações de cronograma feitos na reunião de acompanhamento do Departamento de Monitoramento do Setor Elétrico – DMSE/MME, realizada em 22/07/2021.

Figura 1 - Evolução da potência instalada das UHEs

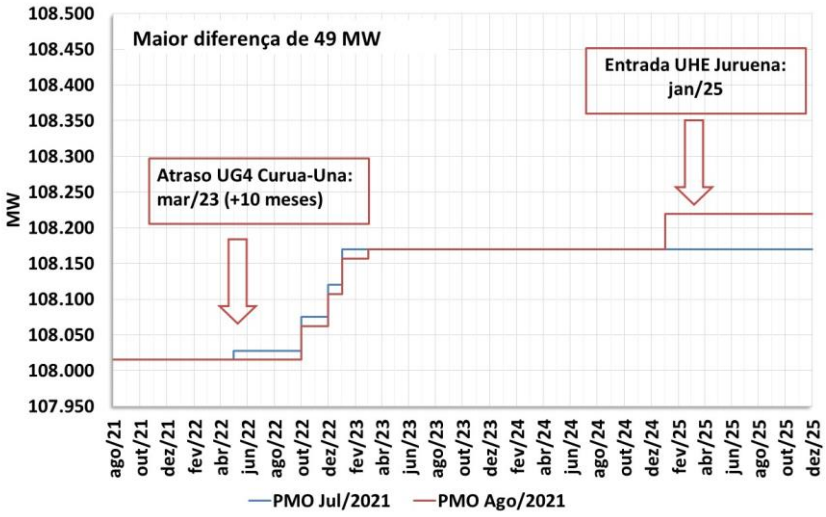


Figura 2 - Evolução da potência instalada das UTEs

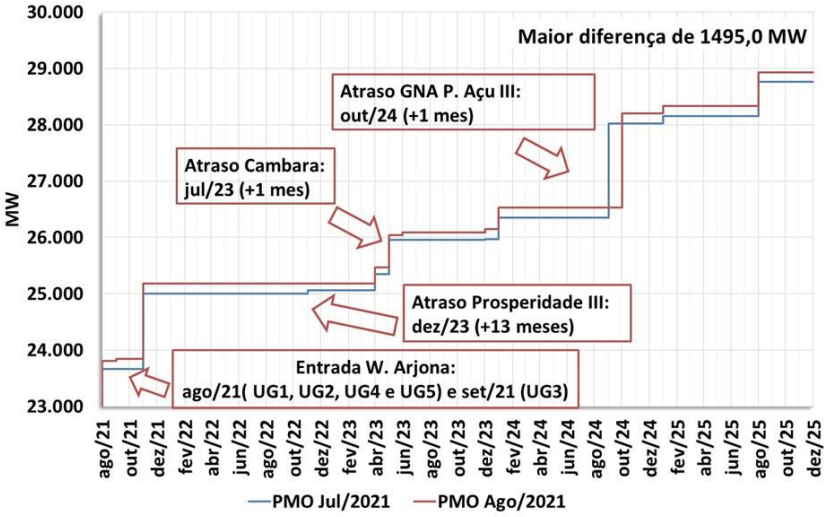


O conteúdo desta publicação foi produzido pelo ONS com base em dados e informações de conhecimento público. É de responsabilidade exclusiva dos agentes e demais interessados a obtenção de outros dados e informações, a realização de análises, estudos e avaliações para fins de tomada de decisões, definição de estratégias de atuação, assunção de compromissos e obrigações e quaisquer outras finalidades, em qualquer tempo e sob qualquer condição. É proibida a reprodução ou utilização total ou parcial do presente sem a identificação da fonte.

Figura 3 - Evolução da disponibilidade das usinas não simuladas

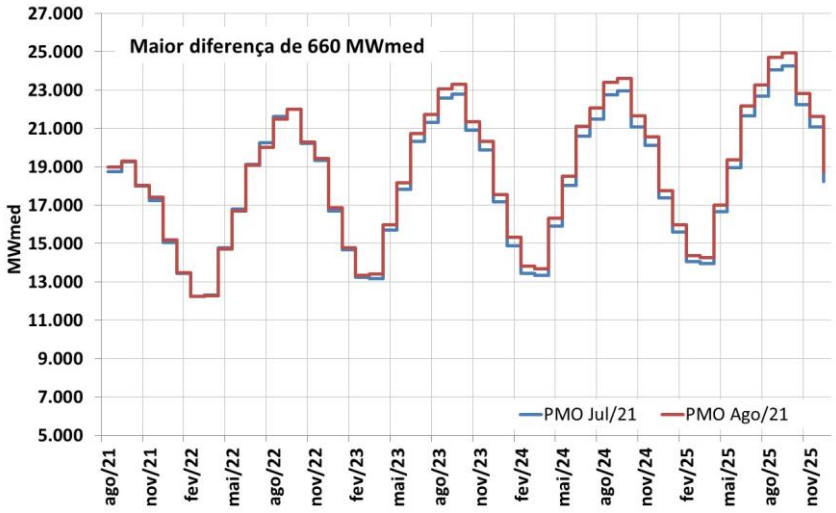


### 3.1.2. Armazenamentos Iniciais

Na Figura 4, a seguir, são apresentados os armazenamentos iniciais equivalentes por subsistema, considerados nos modelos de otimização para a elaboração do PMO de agosto/2021, comparados com os do PMO de julho/2021.

Figura 4 - Energia armazenada inicial em julho/21 e agosto/21 – [% EARmáx]

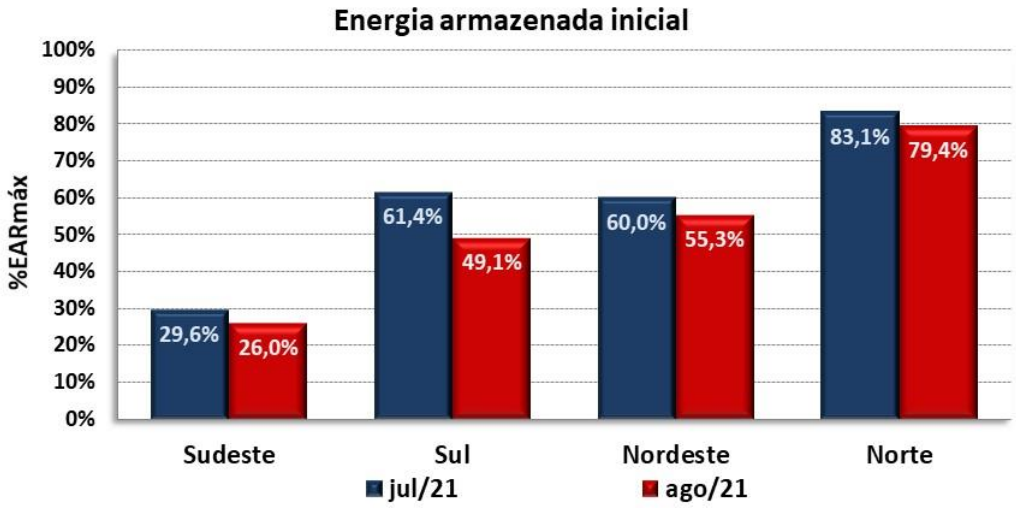


### 3.1.3. Tendência Hidrológica

Na Tabela 1, a seguir, são apresentadas as tendências hidrológicas consideradas pelo modelo NEWAVE para o PMO de Agosto/2021, comparadas com o PMO de Julho/2021.

O conteúdo desta publicação foi produzido pelo ONS com base em dados e informações de conhecimento público. É de responsabilidade exclusiva dos agentes e demais interessados a obtenção de outros dados e informações, a realização de análises, estudos e avaliações para fins de tomada de decisões, definição de estratégias de atuação, assunção de compromissos e obrigações e quaisquer outras finalidades, em qualquer tempo e sob qualquer condição. É proibida a reprodução ou utilização total ou parcial do presente sem a identificação da fonte.

Tabela 1 – Tendência hidrológica para o PMO de Agosto/2021 – NEWAVE [%MLT]

| | PMO Julho/2021 | | | | PMO Agosto/2021 | | | |
|---|---|---|---|---|---|---|---|---|
| MÊS | SE/CO | S | NE | N | SE/CO | S | NE | N |
| jan/21 | 70 | 154 | 47 | 54 | | | | |
| fev/21 | 73 | 122 | 42 | 70 | 73 | 122 | 42 | 70 |
| mar/21 | 75 | 69 | 70 | 109 | 75 | 69 | 70 | 109 |
| abr/21 | 64 | 35 | 35 | 87 | 64 | 35 | 35 | 87 |
| mai/21 | 64 | 29 | 37 | 86 | 63 | 29 | 37 | 86 |
| jun/21 | 67 | 58 | 38 | 72 | 66 | 58 | 38 | 72 |
| ago/21 | | | | | 61 | 44 | 42 | 81 |

* ≥100% MLT < 100% MLT

## 3.2. DEMAIS ATUALIZAÇÕES

Adicionalmente, neste PMO ocorreram os seguintes destaques:

- Horizonte de estudo: agosto de 2021 a dezembro de 2025;
- Utilização da versão 27.0.1 do modelo NEWAVE, conforme Despacho SRG/ANEEL nº 2.132/2021;
- Cronograma de Obras – Reunião DMSE-G de 22/07/2021, com destaque para a inclusão da UHE Juruena (50 MW) na oferta hidráulica em expansão. Foram incluídos os montantes referentes às usinas vendedoras do 33º LEN (A-3 2021) e 34º LEN (A-4 2021);
- CVUs de UTEs vendedoras em leilão;
- CVU da UTE Cuiabá (válido até abr/22), conforme Despacho SRG/ANEEL nº 1.970/2021;
- CVU da UTE W. Arjona (válido até set/21), conforme Despacho SRG/ANEEL nº 2.270/2021;
- CVU da UTE W. Araucária (válido até ago/21), conforme Despacho SRG/ANEEL nº 2.268/2021;
- CVU das UTEs NorteFluminense 1, 2, 3, 4, Termopernambuco e Jorge Lacerda A1, A2, B e C, conforme Despachos SRG/ANEEL nº 2.242/2021, 2.243/2021 e 2.260/2021;
- Alterações de restrições operativas para as UHEs A. A. Laydner, Jupiá, P. Primavera, Chavantes, Ilha Solteira e Três Irmãos de acordo com os FSAR-H enviados pelos Agentes responsáveis;
- Compatibilização da disponibilidade térmica para os dois primeiros meses de acordo com informação da programação mensal segundo Procedimentos de Rede do ONS (Submódulo 4.3 – Programação mensal da operação energética);
- Compatibilização dos valores da geração hidráulica mínima da UHE Itaipu dos dois primeiros meses com os utilizados na programação mensal;
- Restrições de defluências das usinas do Rio São Francisco conforme “Informe Sobre o Planejamento e a Programação da Operação dos Aproveitamentos Hidroelétricos da Bacia do Rio São Francisco no PMO de Agosto de 2021”;
- Atualização dos limites de transmissão entre subsistemas, para os meses de agosto e setembro de 2021.

O conteúdo desta publicação foi produzido pelo ONS com base em dados e informações de conhecimento público. É de responsabilidade exclusiva dos agentes e demais interessados a obtenção de outros dados e informações, a realização de análises, estudos e avaliações para fins de tomada de decisões, definição de estratégias de atuação, assunção de compromissos e obrigações e quaisquer outras finalidades, em qualquer tempo e sob qualquer condição. É proibida a reprodução ou utilização total ou parcial do presente sem a identificação da fonte.

## 4. ANÁLISE DAS CONDIÇÕES HIDROMETEOROLÓGICAS

Na próxima semana operativa, a precipitação fica restrita ao extremo norte do país, atingindo apenas o final da cascata do Xingu (Figura 5). Para as bacias hidrográficas de interesse do SIN não há previsão de precipitação significativa.

Figura 5 - Precipitação acumulada prevista pelo modelo ECMWF (ECMWF) para o período de 31/07/2021 a 06/08/2021.

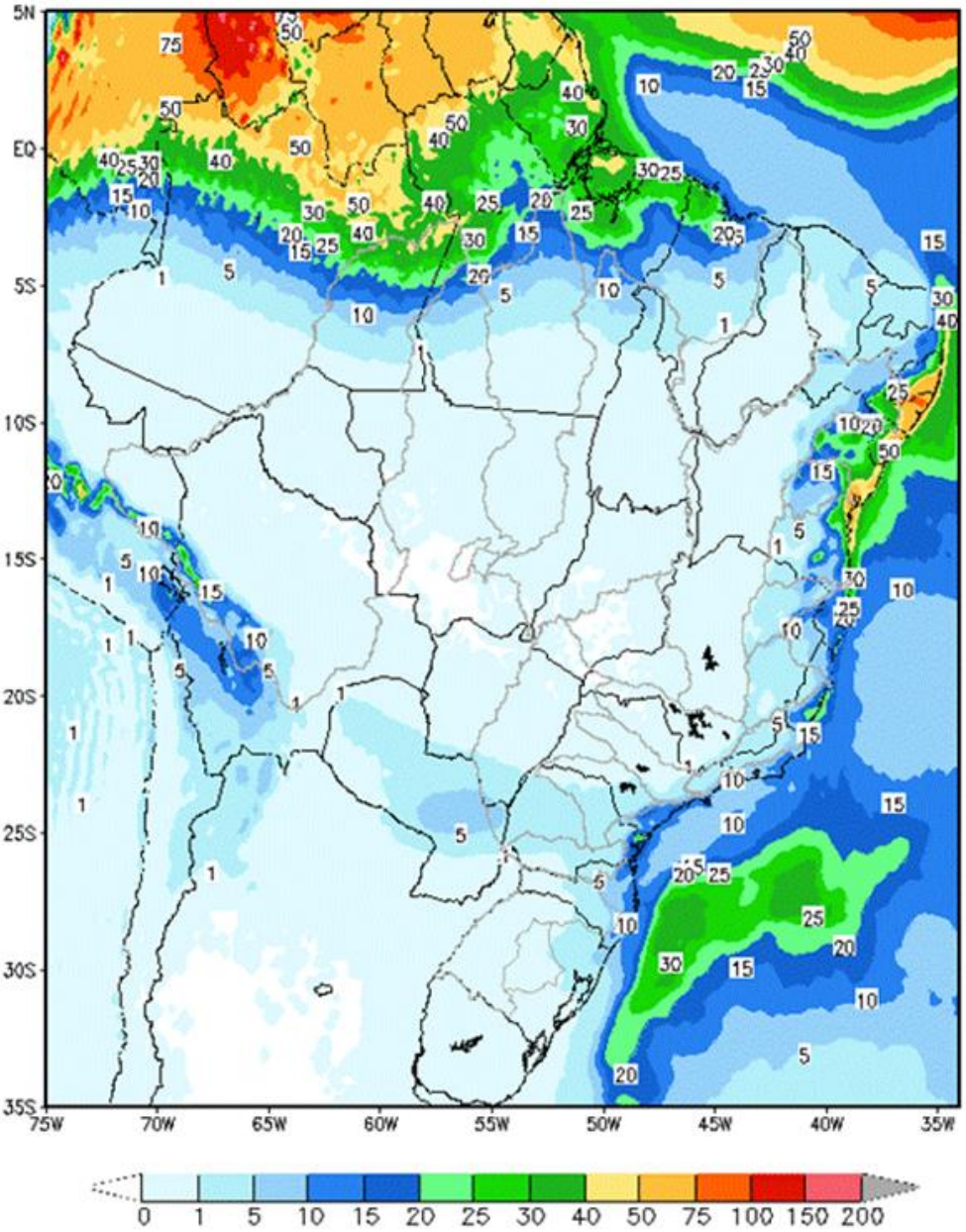


Em comparação com os valores estimados para a semana em curso, prevê-se para a próxima semana operativa recessão nas afluências de todos os subsistemas. A previsão mensal para agosto indica a ocorrência de afluências abaixo da média histórica para todos os subsistemas.

O conteúdo desta publicação foi produzido pelo ONS com base em dados e informações de conhecimento público. É de responsabilidade exclusiva dos agentes e demais interessados a obtenção de outros dados e informações, a realização de análises, estudos e avaliações para fins de tomada de decisões, definição de estratégias de atuação, assunção de compromissos e obrigações e quaisquer outras finalidades, em qualquer tempo e sob qualquer condição. É proibida a reprodução ou utilização total ou parcial do presente sem a identificação da fonte.

Tabela 2 – Previsão de ENAs do PMO de Agosto/2021

| PMO de Agosto/2021 - ENAs previstas | | | | |
|---|---|---|---|---|
| Subsistema | 31/07 a 06/08/2021 | | Mês de agosto | |
| | MWmed | %MLT | MWmed | %MLT |
| SE/CO | 13.026 | 61 | 11.992 | 58 |
| S | 3.211 | 32 | 4.157 | 42 |
| NE | 1.526 | 45 | 1.454 | 44 |
| N | 3.164 | 90 | 2.586 | 80 |

## 5. PREVISÃO DE CARGA

O avanço na vacinação está permitindo uma recuperação da economia brasileira mais forte que a esperada no início do ano. Ainda que se tenha muita incerteza no ambiente econômico, os dados de atividade realizados mostram uma trajetória positiva observada nos últimos meses. A expectativa para os próximos meses, segundo o resultado de diversos indicadores é que o setor industrial se mantenha em patamares elevados principalmente daquelas indústrias voltadas para exportação. Além disso, colaborando para a recuperação, há perspectiva de uma "normalização" das atividades do setor de serviços, onde se concentra cerca de 70% do emprego gerado no país.

As previsões meteorológicas para a próxima semana operativa indicam ocorrência de temperaturas semelhantes às observadas na semana em curso nas capitais das regiões Sudeste/ C. Oeste e Sul, período marcado por temperaturas amenas em função da intensificação da massa de ar frio após a passagem de uma frente fria.

Para as capitais dos subsistemas Norte e Nordeste as sinalizações meteorológicas indicam manutenção das condições de temperaturas e precipitação observadas ao longo das últimas semanas, típicas para essa época do ano.

As taxas de crescimento previstas para o mês de agosto em relação ao mesmo mês do ano anterior, são de 4,2% para os subsistemas Sudeste/Centro-Oeste, 3,6% para o subsistema Sul, 7,6% no Nordeste e 3,7% no subsistema do Norte.

Tabela 3 – Evolução da carga do PMO de Agosto 2021

| Subsistema | CARGA SEMANAL (MWmed) | | | | | CARGA MENSAL (MWmed) | |
|---|---|---|---|---|---|---|---|
| | 1ª Sem | 2ª Sem | 3ª Sem | 4ª Sem | 5ª Sem | ago/21 | Var. (%) ago/21 -> ago/20 |
| SE/CO | 37.587 | 38.838 | 39.448 | 39.643 | 39.659 | 39.021 | 4,2% |
| Sul | 11.450 | 11.432 | 11.393 | 11.384 | 11.350 | 11.405 | 3,6% |
| Nordeste | 11.005 | 11.072 | 11.159 | 11.157 | 11.166 | 11.110 | 7,6% |
| Norte | 5.952 | 6.015 | 6.086 | 6.101 | 6.131 | 6.053 | 3,7% |
| **SIN** | **65.994** | **67.357** | **68.086** | **68.285** | **68.306** | **67.589** | **4,6%** |

O conteúdo desta publicação foi produzido pelo ONS com base em dados e informações de conhecimento público. É de responsabilidade exclusiva dos agentes e demais interessados a obtenção de outros dados e informações, a realização de análises, estudos e avaliações para fins de tomada de decisões, definição de estratégias de atuação, assunção de compromissos e obrigações e quaisquer outras finalidades, em qualquer tempo e sob qualquer condição. É proibida a reprodução ou utilização total ou parcial do presente sem a identificação da fonte.

## 6. PRINCIPAIS RESULTADOS

### 6.1. CUSTO MARGINAL DE OPERAÇÃO (CMO)

A tabela a seguir apresenta o CMO, por subsistema e patamar de carga para próxima semana operativa.

Tabela 4 – CMO por patamar de carga

| Patamares de Carga | CMO (R$/MWh) | | | |
|---|---|---|---|---|
| | SE/CO | S | NE | N |
| Pesada | 2.603,45 | 2.603,45 | 2.603,45 | 2.603,45 |
| Média | 2.596,82 | 2.596,82 | 2.596,82 | 2.596,82 |
| Leve | 2.464,64 | 2.464,64 | 2.464,64 | 2.464,64 |
| Média Semanal | 2.540,18 | 2.540,18 | 2.540,18 | 2.540,18 |

Na figura a seguir é apresentada a evolução do CMO médio semanal ao longo deste PMO.

Figura 6 – Evolução semanal do CMO

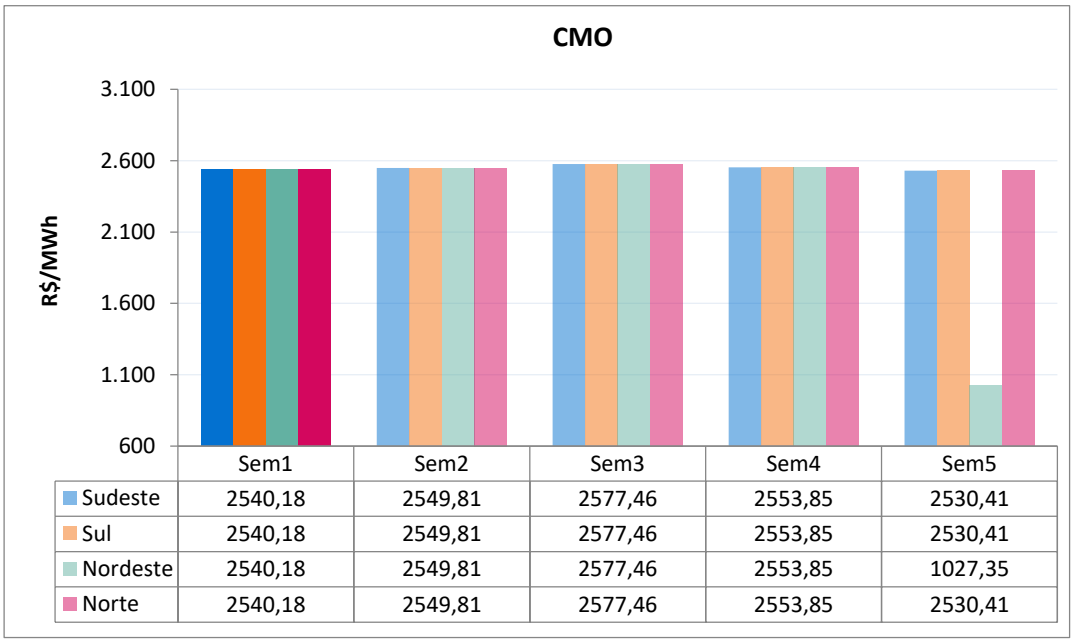


### 6.2. POLÍTICA DE OPERAÇÃO ENERGÉTICA

Para esta semana operativa, está prevista a seguinte política de intercâmbio de energia entre regiões:

Região SE/CO → Geração minimizada de acordo com os condicionantes hidráulicos.

Região Sul → Geração dimensionada para fechamento do balanço energético do SIN.

Região NE → Aumento da geração eólica e exportação de energia, modulando em função de seus recursos energéticos, respeitando-se os limites elétricos vigentes.

Região Norte → Redução da exploração das disponibilidades energéticas, respeitando-se os limites elétricos vigentes.

O conteúdo desta publicação foi produzido pelo ONS com base em dados e informações de conhecimento público. É de responsabilidade exclusiva dos agentes e demais interessados a obtenção de outros dados e informações, a realização de análises, estudos e avaliações para fins de tomada de decisões, definição de estratégias de atuação, assunção de compromissos e obrigações e quaisquer outras finalidades, em qualquer tempo e sob qualquer condição. É proibida a reprodução ou utilização total ou parcial do presente sem a identificação da fonte.

## 7. ANÁLISE DA VARIAÇÃO SEMANAL DO CMO

Esta análise visa identificar os principais parâmetros cujas atualizações impactaram os CMO deste PMO, em comparação com os valores obtidos na última revisão.

Foram realizados 8 estudos, onde caso inicial, denominado "acoplamento com a FCF" foi construído com base nos dados preliminares para este PMO, utilizando a Função de Custo Futuro e previsão de vazões elaboradas para este PMO. Os níveis de partida dos reservatórios são os estimados conforme indicado para esta semana na última revisão do PMO anterior.

A partir do conjunto de dados do primeiro estudo foram elaborados os demais casos em que foram atualizados, sequencialmente, as seguintes informações: níveis de partida dos reservatórios, previsão de carga, disponibilidade das usinas térmicas e hidráulicas, restrições de limites de intercâmbio, restrições hidráulicas e, por fim, os demais dados que compõem toda informação referente a atual revisão.

Os custos marginais de operação dos quatro subsistemas que compõem o SIN permanecem acoplados e são apresentados na Figura 7. A atualização das condições de acoplamento, níveis de partida, previsão de carga e alterações nas disponibilidades das usinas térmicas e hidráulicas foram os fatores que contribuíram para a elevação dos CMO dos subsistemas SE/CO, S, NE e N.

Figura 7 – Análise da variação do CMO nos subsistemas SE/CO, S, NE e N

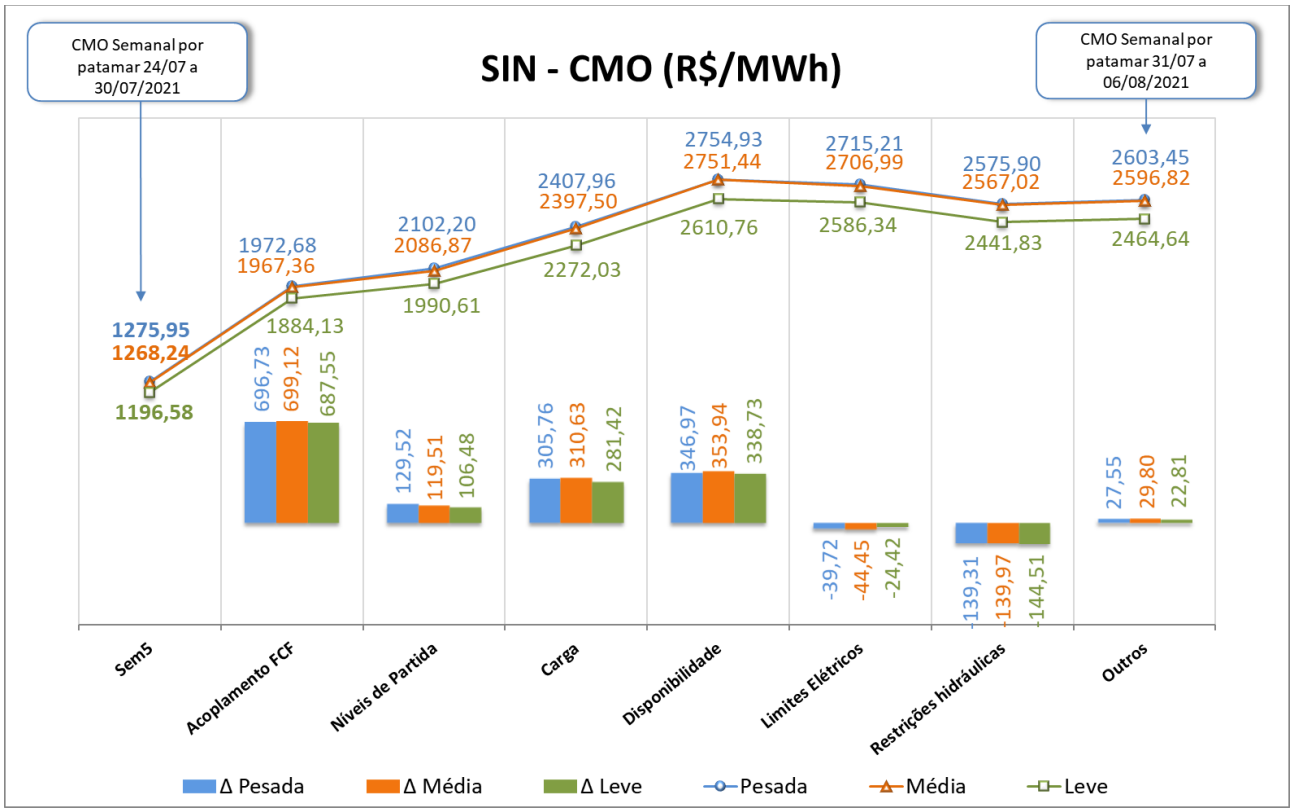


O conteúdo desta publicação foi produzido pelo ONS com base em dados e informações de conhecimento público. É de responsabilidade exclusiva dos agentes e demais interessados a obtenção de outros dados e informações, a realização de análises, estudos e avaliações para fins de tomada de decisões, definição de estratégias de atuação, assunção de compromissos e obrigações e quaisquer outras finalidades, em qualquer tempo e sob qualquer condição. É proibida a reprodução ou utilização total ou parcial do presente sem a identificação da fonte.

## 8. GERAÇÃO TÉRMICA

A Figura 8 apresenta, para cada subsistema, o despacho térmico por modalidade indicado pelo Decomp para a próxima semana operativa.

Figura 8 – Geração térmica para a próxima semana operativa

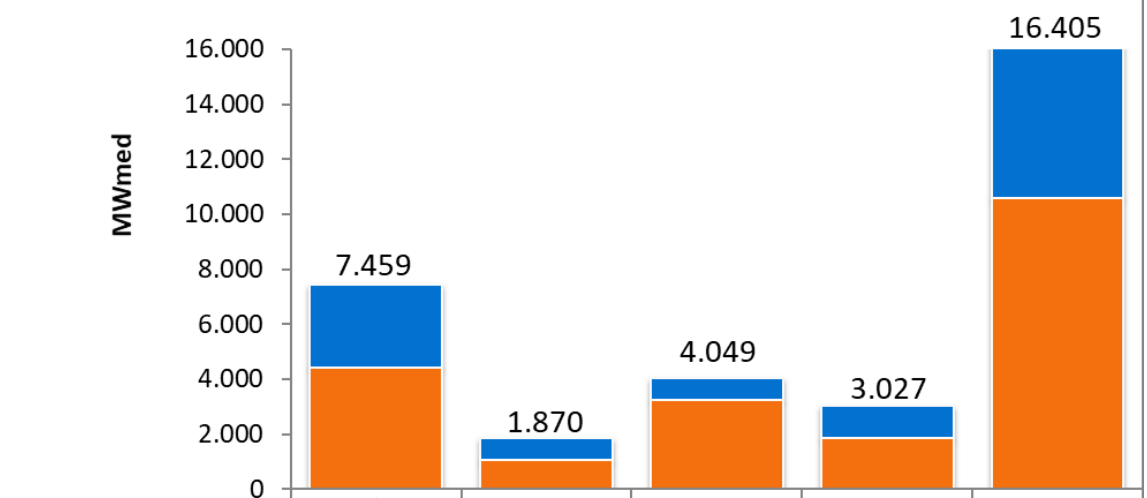


| | SE/CO | SUL | NE | NORTE | SIN |
|---|---|---|---|---|---|
| RESTRIÇÃO ELÉTRICA | 0 | 0 | 0 | 0 | 0 |
| INFLEXIBILIDADE | 3049 | 789 | 806 | 1165 | 5809 |
| ORDEM DE MÉRITO | 4410 | 1081 | 3243 | 1862 | 10596 |

Na tabela abaixo segue a Indicação de despacho antecipado por ordem de mérito de custo para a semana de 02/10/2021 a 08/10/2021.

Tabela 5 – UTEs com contrato de combustível GNL

| UTE | | | Benefício (R$/MWh) | | |
|---|---|---|---|---|---|
| Nome | Cod | CVU (R$/MWh) | Carga Pesada | Carga Média | Carga Leve |
| SANTA CRUZ | 86 | 227,91 | 1487,69 (1) | 1487,69 (1) | 1486,18 (1) |
| LUIZORMELO | 15 | 348,84 | 1487,69 (1) | 1487,69 (1) | 1486,18 (1) |
| PSERGIPE I | 224 | 306,97 | 320,69 (1) | 320,63 (1) | 320,63 (1) |

(1) Comandado o despacho antecipado por ordem de mérito de custo nesse patamar

(2) NÃO foi comandado o despacho antecipado por ordem de mérito de custo nesse patamar

Assim sendo, há previsão de despacho antecipado por ordem de mérito de custo para as UTE Santa Cruz, Luiz O. R. Melo e Porto Sergipe I, para a semana de 02/10 a 08/10/2021.

O conteúdo desta publicação foi produzido pelo ONS com base em dados e informações de conhecimento público. É de responsabilidade exclusiva dos agentes e demais interessados a obtenção de outros dados e informações, a realização de análises, estudos e avaliações para fins de tomada de decisões, definição de estratégias de atuação, assunção de compromissos e obrigações e quaisquer outras finalidades, em qualquer tempo e sob qualquer condição. É proibida a reprodução ou utilização total ou parcial do presente sem a identificação da fonte.

## 9. IMPORTAÇÃO DE ENERGIA DA REPÚBLICA ORIENTAL DO URUGUAI

### 9.1. República Oriental do Uruguai

Para a próxima semana operativa, foram declaradas as seguintes ofertas de importação de energia da República Oriental do Uruguai para o Sistema Interligado Nacional - SIN através das conversoras de Rivera (70 MW) e Melo (500 MW).

- **Eletrobras**

Tabela 6 – Energia ofertada para importação

| | Oferta de Energia para a Semana de 31/07 a 06/08 (MWmed) | | | | |
|---|---|---|---|---|---|
| | Bloco 1 | Bloco 2 | Bloco 3 | Bloco 4 | Total |
| Carga Pesada | 100 | 50 | 85 | 50 | 285 |
| Carga Média | 100 | 50 | 85 | 50 | 285 |
| Carga Leve | 100 | 50 | 85 | 50 | 285 |
| CVU (R$/MWh) | 944,38 | 1.213,96 | 1.564,48 | 1.751,35 | |

- **Enel**

Conforme declaração do agente, esta importação poderá ser realizada exclusivamente pela conversora Melo.

Tabela 7 – Energia ofertada para importação

| | Oferta de Energia para a Semana de 31/07 a 06/08 (MWmed) | | | | |
|---|---|---|---|---|---|
| | Bloco 1 | Bloco 2 | Bloco 3 | Bloco 4 | Total |
| Carga Pesada | 100 | 50 | 85 | 50 | 285 |
| Carga Média | 100 | 50 | 85 | 50 | 285 |
| Carga Leve | 100 | 50 | 85 | 50 | 285 |
| CVU (R$/MWh) | 959,81 | 1.229,98 | 1.589,46 | 1.778,66 | |

O conteúdo desta publicação foi produzido pelo ONS com base em dados e informações de conhecimento público. É de responsabilidade exclusiva dos agentes e demais interessados a obtenção de outros dados e informações, a realização de análises, estudos e avaliações para fins de tomada de decisões, definição de estratégias de atuação, assunção de compromissos e obrigações e quaisquer outras finalidades, em qualquer tempo e sob qualquer condição. É proibida a reprodução ou utilização total ou parcial do presente sem a identificação da fonte.

## 9.2. República da Argentina

- **Enel**

Para a próxima semana operativa, foi declarada a seguinte oferta de importação de energia da República da Argentina para o SIN através das conversoras de Garabi 1 (1.100 MW) e Garabi 2 (1.100 MW).

Tabela 8 – Energia ofertada para importação

| | Oferta de Energia para a Semana de 31/07 a 06/08 (MWmed) | | |
|---|---|---|---|
| | Bloco 1 | Bloco 2 | Total |
| Carga Pesada | 300 | 800 | 1.100 |
| Carga Média | 300 | 800 | 1.100 |
| Carga Leve | 300 | 800 | 1.100 |
| CVU (R$/MWh) | 1.296,57 | 1.483,51 | |

Nota: Detalhes sobre a importação de energia vide Portaria Nº 339, de 15 de agosto de 2018 disponível em: http://pesquisa.in.gov.br/imprensa/jsp/visualiza/index.jsp?data=17/08/2018&jornal=515&pagina=60&totalArquivos=136

O conteúdo desta publicação foi produzido pelo ONS com base em dados e informações de conhecimento público. É de responsabilidade exclusiva dos agentes e demais interessados a obtenção de outros dados e informações, a realização de análises, estudos e avaliações para fins de tomada de decisões, definição de estratégias de atuação, assunção de compromissos e obrigações e quaisquer outras finalidades, em qualquer tempo e sob qualquer condição. É proibida a reprodução ou utilização total ou parcial do presente sem a identificação da fonte.

## 10. ARMAZENAMENTOS OPERATIVOS

Para uma melhor avaliação de diversos cenários hidrometeorológicos, notadamente, aqueles de curto prazo e suas influências nas previsões de vazões nos subsistemas, os resultados deste PMO contemplam cenários de afluências visando melhor representar a ocorrência de precipitação e, consequentemente, seus efeitos sobre as afluências e armazenamentos.

Além dos resultados associados ao valor esperado das previsões de afluências, as simulações operativas também foram realizadas com os limites superior e inferior das previsões de afluências. Apresentamos a seguir os resultados obtidos com a aplicação dos diferentes cenários de afluência.

Tabela 9 – Previsão de ENA dos cenários de sensibilidade

| Subsistema | ENERGIAS NATURAIS AFLUENTES | | | | | |
|---|---|---|---|---|---|---|
| | Previsão Mensal | | | | | |
| | LI | | VE | | LS | |
| | (MWmed) | %MLT | (MWmed) | %MLT | (MWmed) | %MLT |
| SE/CO | 10.420 | **51** | 11.992 | **58** | 13.550 | **66** |
| Sul | 1.856 | **19** | 4.157 | **42** | 7.325 | **73** |
| Nordeste | 1.288 | **39** | 1.454 | **44** | 1.624 | **49** |
| Norte | 2.315 | **72** | 2.586 | **80** | 2.857 | **89** |

Tabela 10 – Previsão de %EARmáx para o final do mês

| Subsistema | % EARmáx 30/07 | % EARmáx - 31/08 | | |
|---|---|---|---|---|
| | NÍVEL INICIAL | NÍVEL PMO | | |
| | VE | LI | VE | LS |
| SE/CO | 25,9 | 19,8 | 21,4 | 23,0 |
| Sul | 49,1 | 21,4 | 25,6 | 33,0 |
| Nordeste | 55,3 | 48,6 | 49,0 | 49,3 |
| Norte | 79,4 | 73,9 | 74,1 | 74,3 |

O conteúdo desta publicação foi produzido pelo ONS com base em dados e informações de conhecimento público. É de responsabilidade exclusiva dos agentes e demais interessados a obtenção de outros dados e informações, a realização de análises, estudos e avaliações para fins de tomada de decisões, definição de estratégias de atuação, assunção de compromissos e obrigações e quaisquer outras finalidades, em qualquer tempo e sob qualquer condição. É proibida a reprodução ou utilização total ou parcial do presente sem a identificação da fonte.

## 11. RESERVATÓRIOS EQUIVALENTES DE ENERGIA

A seguir são apresentadas as previsões de Energia Natural Afluente para a próxima semana operativa e para o mês de agosto, bem como as previsões de Energia Armazenada nos Reservatórios Equivalentes de Energia – REE, deste PMO.

Tabela 11 – Previsão de ENA por REE

| Valor Esperado das Energias Naturais Afluentes | | | | |
|---|---|---|---|---|
| REE | Previsão Semanal | | Previsão Mensal | |
| | 31/07/2021 a 06/08/2021 | | ago/21 | |
| | (MWmed) | %MLT | (MWmed) | %MLT |
| Sudeste | 1.643 | 65 | 1.525 | 62 |
| Madeira | 2.360 | 91 | 1.930 | 81 |
| Teles Pires | 640 | 79 | 576 | 74 |
| Itaipu | 1.822 | 68 | 1.781 | 68 |
| Paraná | 5.687 | 53 | 5.331 | 51 |
| Paranapanema | 838 | 43 | 822 | 44 |
| Sul | 2.124 | 36 | 2.931 | 49 |
| Iguaçu | 1.088 | 26 | 1.226 | 30 |
| Nordeste | 1.526 | 45 | 1.454 | 44 |
| Norte | 1.457 | 75 | 1.269 | 69 |
| Belo Monte | 642 | 79 | 428 | 64 |
| Manaus | 1.182 | 157 | 935 | 133 |

Tabela 12 – Previsão de %EARmáx por REE

| % Energia Armazenável Máxima | | |
|---|---|---|
| REE | Previsão Semanal | Previsão Mensal |
| | 06/ago | 31/ago |
| | (%EARmáx) | (%EARmáx) |
| Sudeste | 34,0 | 29,5 |
| Madeira | 65,2 | 34,4 |
| Teles Pires | 67,2 | 52,0 |
| Itaipu | 22,1 | 67,9 |
| Paraná | 20,5 | 16,7 |
| Paranapanema | 37,6 | 37,3 |
| Sul | 47,6 | 31,8 |
| Iguaçu | 42,8 | 20,0 |
| Nordeste | 54,0 | 49,0 |
| Norte | 77,8 | 73,9 |
| Belo Monte | 98,3 | 82,3 |
| Manaus | 94,3 | 77,8 |

O conteúdo desta publicação foi produzido pelo ONS com base em dados e informações de conhecimento público. É de responsabilidade exclusiva dos agentes e demais interessados a obtenção de outros dados e informações, a realização de análises, estudos e avaliações para fins de tomada de decisões, definição de estratégias de atuação, assunção de compromissos e obrigações e quaisquer outras finalidades, em qualquer tempo e sob qualquer condição. É proibida a reprodução ou utilização total ou parcial do presente sem a identificação da fonte.

## 12. DESPACHO TÉRMICO POR MODALIDADE, PATAMAR DE CARGA E USINA

Nas tabelas abaixo, a diferenciação entre geração por inflexibilidade e por ordem de mérito tem caráter informativo, com o objetivo de detalhar a informação de inflexibilidade enviada pelos respectivos agentes para o PMO. Ressalta-se que nas etapas de Programação Diária e Tempo Real, o montante despachado nas usinas termelétricas indicadas por ordem de mérito é plenamente intitulado como ordem de mérito.

**REGIÃO SUDESTE/CENTRO-OESTE**

| Térmicas Potência (MW) | Combustível | CVU (R$/MWh) | Inflexibilidade | | | Ordem de Mérito | | | Total Mérito e INFL. | | | Razão Elétrica | | | Total UTE | | |
|---|---|---|---|---|---|---|---|---|---|---|---|---|---|---|---|---|---|
| | | | P | M | L | P | M | L | P | M | L | P | M | L | P | M | L |
| ATLAN_CSA (255) | Resíduos | 0,00 | 121,0 | 121,0 | 121,0 | | | | 121,0 | 121,0 | 121,0 | | | | 121,0 | 121,0 | 121,0 |
| ANGRA 2 (1350) | Nuclear | 20,12 | 1350,0 | 1350,0 | 1350,0 | 0,0 | 0,0 | 0,0 | 1350,0 | 1350,0 | 1350,0 | | | | 1350,0 | 1350,0 | 1350,0 |
| ANGRA 1 (640) | Nuclear | 31,17 | 640,0 | 640,0 | 640,0 | 0,0 | 0,0 | 0,0 | 640,0 | 640,0 | 640,0 | | | | 640,0 | 640,0 | 640,0 |
| NORTEFLU 1 (400) | Gás | 80,11 | 400,0 | 400,0 | 400,0 | 0,0 | 0,0 | 0,0 | 400,0 | 400,0 | 400,0 | | | | 400,0 | 400,0 | 400,0 |
| NORTEFLU 2 (100) | Gás | 92,32 | 100,0 | 100,0 | 100,0 | 0,0 | 0,0 | 0,0 | 100,0 | 100,0 | 100,0 | | | | 100,0 | 100,0 | 100,0 |
| O.PINTADA (50) | Biomassa | 112,47 | 5,0 | 5,0 | 5,0 | 45,0 | 45,0 | 45,0 | 50,0 | 50,0 | 50,0 | | | | 50,0 | 50,0 | 50,0 |
| UTE STA VI (41) | Biomassa | 121,49 | 13,0 | 13,0 | 13,0 | 28,4 | 28,4 | 28,4 | 41,4 | 41,4 | 41,4 | | | | 41,4 | 41,4 | 41,4 |
| PREDILECTA (5) | Biomassa | 158,95 | 1,0 | 1,0 | 1,0 | 4,0 | 4,0 | 4,0 | 5,0 | 5,0 | 5,0 | | | | 5,0 | 5,0 | 5,0 |
| NORTEFLU 3 (200) | Gás | 174,85 | 200,0 | 200,0 | 200,0 | 0,0 | 0,0 | 0,0 | 200,0 | 200,0 | 200,0 | | | | 200,0 | 200,0 | 200,0 |
| ATLANTICO (235) | Resíduos | 204,22 | 218,7 | 218,7 | 218,7 | 0,0 | 0,0 | 0,0 | 218,7 | 218,7 | 218,7 | | | | 218,7 | 218,7 | 218,7 |
| BAIXADA FL (530) | Gás | 224,60 | | | | 530,0 | 530,0 | 530,0 | 530,0 | 530,0 | 530,0 | | | | 530,0 | 530,0 | 530,0 |
| SANTA CRUZ (500) | GNL | 227,91 | | | | 175,0 | 175,0 | 175,0 | 175,0 | 175,0 | 175,0 | | | | 175,0 | 175,0 | 175,0 |
| T.LAGOAS (350) | Gás | 262,77 | | | | 270,0 | 270,0 | 270,0 | 270,0 | 270,0 | 270,0 | | | | 270,0 | 270,0 | 270,0 |
| JUIZ DE FO (87) | Gás | 283,74 | | | | 84,8 | 79,3 | 62,2 | 84,8 | 79,3 | 62,2 | | | | 84,8 | 79,3 | 62,2 |
| ST.CRUZ 34 (436) | Óleo | 310,41 | | | | | | | | | | | | | | | |
| TERMORIO (1036) | Gás | 330,06 | | | | 350,0 | 350,0 | 350,0 | 350,0 | 350,0 | 350,0 | | | | 350,0 | 350,0 | 350,0 |
| LUIZORMELO (204) | GNL | 348,84 | | | | 204,0 | 204,0 | 204,0 | 204,0 | 204,0 | 204,0 | | | | 204,0 | 204,0 | 204,0 |
| CUBATAO (216) | Gás | 353,47 | | | | 209,0 | 209,0 | 209,0 | 209,0 | 209,0 | 209,0 | | | | 209,0 | 209,0 | 209,0 |
| SEROPEDICA (386) | Gás | 410,96 | | | | 353,5 | 353,5 | 353,5 | 353,5 | 353,5 | 353,5 | | | | 353,5 | 353,5 | 353,5 |
| PIRAT.12 O (200) | Gás | 470,34 | | | | | | | | | | | | | | | |
| NPIRATINGA (572) | Gás | 548,04 | | | | 280,0 | 280,0 | 280,0 | 280,0 | 280,0 | 280,0 | | | | 280,0 | 280,0 | 280,0 |
| NORTEFLU 4 (127) | Gás | 604,34 | | | | 126,0 | 126,0 | 126,0 | 126,0 | 126,0 | 126,0 | | | | 126,0 | 126,0 | 126,0 |
| IBIRITE (226) | Gás | 650,77 | | | | 222,0 | 222,0 | 222,0 | 222,0 | 222,0 | 222,0 | | | | 222,0 | 222,0 | 222,0 |
| CUIABA CC (529) | Gás | 701,88 | | | | 490,0 | 490,0 | 490,0 | 490,0 | 490,0 | 490,0 | | | | 490,0 | 490,0 | 490,0 |
| T.MACAE (929) | Gás | 739,19 | | | | 801,2 | 801,2 | 801,2 | 801,2 | 801,2 | 801,2 | | | | 801,2 | 801,2 | 801,2 |
| PALMEIR_GO (176) | Diesel | 763,38 | | | | 0,0 | 0,0 | 0,0 | | | | | | | | | |
| TNORTE 2 (340) | Óleo | 910,86 | | | | 0,0 | 0,0 | 0,0 | | | | | | | | | |
| VIANA (175) | Óleo | 920,04 | | | | 174,6 | 174,6 | 174,6 | 174,6 | 174,6 | 174,6 | | | | 174,6 | 174,6 | 174,6 |
| CAMPOS (25) | Gás | 978,10 | | | | | | | | | | | | | | | |
| DAIA (44) | Diesel | 1019,93 | | | | 0,0 | 0,0 | 0,0 | 0,0 | 0,0 | 0,0 | | | | 0,0 | 0,0 | 0,0 |
| GOIANIA 2 (140) | Diesel | 1066,64 | | | | 0,0 | 0,0 | 0,0 | 0,0 | 0,0 | 0,0 | | | | 0,0 | 0,0 | 0,0 |
| XAVANTES (54) | Diesel | 1465,79 | | | | 53,5 | 53,5 | 53,5 | 53,5 | 53,5 | 53,5 | | | | 53,5 | 53,5 | 53,5 |
| W.ARJONA (177) | Gás | 1741,11 | | | | 20,6 | 20,6 | 20,6 | 20,6 | 20,6 | 20,6 | | | | 20,6 | 20,6 | 20,6 |
| TOTAL SE/CO (10735) | | | 3048,7 | 3048,7 | 3048,7 | 4421,6 | 4416,1 | 4399,0 | 7470,3 | 7464,8 | 7447,7 | 0,0 | 0,0 | 0,0 | 7470,3 | 7464,8 | 7447,7 |

**REGIÃO SUL**

| Térmicas Potência (MW) | Combustível | CVU (R$/MWh) | Inflexibilidade | | | Ordem de Mérito | | | Total Mérito e INFL. | | | Razão Elétrica | | | Total UTE | | |
|---|---|---|---|---|---|---|---|---|---|---|---|---|---|---|---|---|---|
| | | | P | M | L | P | M | L | P | M | L | P | M | L | P | M | L |
| URUGUAIANA (640) | Gás | - | | | | | | | | | | | | | | | |
| PAMPA SUL (345) | Carvão | 69,75 | | | | 0,0 | 0,0 | 0,0 | 0,0 | 0,0 | 0,0 | | | | 0,0 | 0,0 | 0,0 |
| SAO SEPE (8) | Biomassa | 87,75 | 8,0 | 8,0 | 8,0 | 0,0 | 0,0 | 0,0 | 8,0 | 8,0 | 8,0 | | | | 8,0 | 8,0 | 8,0 |
| CANDIOTA_3 (350) | Carvão | 91,59 | 279,0 | 279,0 | 279,0 | 0,0 | 0,0 | 0,0 | 279,0 | 279,0 | 279,0 | | | | 279,0 | 279,0 | 279,0 |
| J.LACER. C (363) | Carvão | 229,27 | 200,0 | 200,0 | 200,0 | 163,0 | 163,0 | 163,0 | 363,0 | 363,0 | 363,0 | | | | 363,0 | 363,0 | 363,0 |
| J.LACER. B (262) | Carvão | 271,21 | 160,0 | 160,0 | 160,0 | 102,0 | 102,0 | 102,0 | 262,0 | 262,0 | 262,0 | | | | 262,0 | 262,0 | 262,0 |
| J.LAC. A2 (132) | Carvão | 278,38 | 70,0 | 70,0 | 70,0 | 62,0 | 62,0 | 62,0 | 132,0 | 132,0 | 132,0 | | | | 132,0 | 132,0 | 132,0 |
| J.LAC. A1 (100) | Carvão | 304,61 | 70,0 | 70,0 | 70,0 | 30,0 | 30,0 | 30,0 | 100,0 | 100,0 | 100,0 | | | | 100,0 | 100,0 | 100,0 |
| MADEIRA (4) | Biomassa | 325,32 | 2,0 | 2,0 | 2,0 | 1,0 | 1,0 | 1,0 | 3,0 | 3,0 | 3,0 | | | | 3,0 | 3,0 | 3,0 |
| FIGUEIRA (20) | Carvão | 475,68 | | | | 0,0 | 0,0 | 0,0 | 0,0 | 0,0 | 0,0 | | | | 0,0 | 0,0 | 0,0 |
| CANOAS (249) | Diesel | 698,14 | | | | 243,1 | 243,1 | 243,1 | 243,1 | 243,1 | 243,1 | | | | 243,1 | 243,1 | 243,1 |
| ARAUCARIA (484) | Gás | 1083,21 | | | | 480,0 | 480,0 | 480,0 | 480,0 | 480,0 | 480,0 | | | | 480,0 | 480,0 | 480,0 |
| TOTAL SUL (2957) | | | 789,0 | 789,0 | 789,0 | 1081,1 | 1081,1 | 1081,1 | 1870,1 | 1811,9 | 1742,1 | 0,0 | 0,0 | 0,0 | 1870,1 | 1870,1 | 1870,1 |

O conteúdo desta publicação foi produzido pelo ONS com base em dados e informações de conhecimento público. É de responsabilidade exclusiva dos agentes e demais interessados a obtenção de outros dados e informações, a realização de análises, estudos e avaliações para fins de tomada de decisões, definição de estratégias de atuação, assunção de compromissos e obrigações e quaisquer outras finalidades, em qualquer tempo e sob qualquer condição. É proibida a reprodução ou utilização total ou parcial do presente sem a identificação da fonte.

**REGIÃO NORDESTE**

| Térmicas Potência (MW) | Combustível | CVU (R$/MWh) | Inflexibilidade | | | Ordem de Mérito | | | Total Mérito e INFL. | | | Razão Elétrica | | | Total UTE | | |
|---|---|---|---|---|---|---|---|---|---|---|---|---|---|---|---|---|---|
| | | | P | M | L | P | M | L | P | M | L | P | M | L | P | M | L |
| ALTOS (13) | Diesel | - | | | | | | | | | | | | | | | |
| ARACATI (11) | Diesel | - | | | | | | | | | | | | | | | |
| BATURITE (11) | Diesel | - | | | | | | | | | | | | | | | |
| C.MAIOR (13) | Diesel | - | | | | | | | | | | | | | | | |
| CAUCAIA (15) | Diesel | - | | | | | | | | | | | | | | | |
| CRATO (13) | Diesel | - | | | | | | | | | | | | | | | |
| IGUATU (15) | Diesel | - | | | | | | | | | | | | | | | |
| JUAZEIRO N (15) | Diesel | - | | | | | | | | | | | | | | | |
| MARAMBAIA (13) | Diesel | - | | | | | | | | | | | | | | | |
| NAZARIA (13) | Diesel | - | | | | | | | | | | | | | | | |
| PECEM (15) | Diesel | - | | | | | | | | | | | | | | | |
| ERB CANDEI (17) | Biomassa | 87,81 | 4,5 | 4,5 | 4,5 | 6,5 | 6,5 | 6,5 | 11,0 | 11,0 | 11,0 | | | | 11,0 | 11,0 | 11,0 |
| PROSPERIDA (28) | Gás | 165,61 | | | | 28,0 | 28,0 | 28,0 | 28,0 | 28,0 | 28,0 | | | | 28,0 | 28,0 | 28,0 |
| TERMOPE (533) | Gás | 168,43 | 532,7 | 532,7 | 532,7 | 0,0 | 0,0 | 0,0 | 532,7 | 532,7 | 532,7 | | | | 532,7 | 532,7 | 532,7 |
| FORTALEZA (327) | Gás | 245,46 | | | | 326,6 | 326,6 | 326,6 | 326,6 | 326,6 | 326,6 | | | | 326,6 | 326,6 | 326,6 |
| PSERGIPE I (1516) | GNL | 306,97 | | | | | | | | | | | | | | | |
| P.PECEM1 (720) | Carvão | 318,63 | | | | 720,0 | 720,0 | 720,0 | 720,0 | 720,0 | 720,0 | | | | 720,0 | 720,0 | 720,0 |
| P.PECEM2 (365) | Carvão | 321,70 | | | | 365,0 | 365,0 | 365,0 | 365,0 | 365,0 | 365,0 | | | | 365,0 | 365,0 | 365,0 |
| TERMOCEARA (223) | Gás | 431,81 | | | | 0,0 | 0,0 | 0,0 | 0,0 | 0,0 | 0,0 | | | | 0,0 | 0,0 | 0,0 |
| SYKUE I (30) | Biomassa | 510,12 | | | | 0,0 | 0,0 | 0,0 | 0,0 | 0,0 | 0,0 | | | | 0,0 | 0,0 | 0,0 |
| VALE ACU (368) | Gás | 696,57 | 110,0 | 110,0 | 110,0 | 0,0 | 0,0 | 0,0 | 110,0 | 110,0 | 110,0 | | | | 110,0 | 110,0 | 110,0 |
| T.BAHIA (186) | Gás | 715,08 | 158,9 | 158,9 | 158,9 | 0,0 | 0,0 | 0,0 | 158,9 | 158,9 | 158,9 | | | | 158,9 | 158,9 | 158,9 |
| PERNAMBU_3 (201) | Óleo | 792,95 | | | | 0,0 | 0,0 | 0,0 | 0,0 | 0,0 | 0,0 | | | | 0,0 | 0,0 | 0,0 |
| BAHIA_1 (31) | Óleo | 819,14 | | | | 26,0 | 26,0 | 26,0 | 26,0 | 26,0 | 26,0 | | | | 26,0 | 26,0 | 26,0 |
| MARACANAU (168) | Óleo | 894,72 | | | | 121,0 | 118,5 | 115,6 | 121,0 | 118,5 | 115,6 | | | | 121,0 | 118,5 | 115,6 |
| TERMOCABO (50) | Óleo | 908,76 | | | | 33,1 | 33,1 | 33,1 | 33,1 | 33,1 | 33,1 | | | | 33,1 | 33,1 | 33,1 |
| TERMONE (171) | Óleo | 912,28 | | | | 158,0 | 158,0 | 158,0 | 158,0 | 158,0 | 158,0 | | | | 158,0 | 158,0 | 158,0 |
| TERMOPB (171) | Óleo | 912,28 | | | | 154,0 | 154,0 | 154,0 | 154,0 | 154,0 | 154,0 | | | | 154,0 | 154,0 | 154,0 |
| CAMPINA_GR (169) | Óleo | 920,06 | | | | 126,0 | 126,0 | 126,0 | 126,0 | 126,0 | 126,0 | | | | 126,0 | 126,0 | 126,0 |
| SUAPE II (381) | Óleo | 940,25 | | | | 358,4 | 358,4 | 357,1 | 358,4 | 358,4 | 357,1 | | | | 358,4 | 358,4 | 357,1 |
| POTIGUAR_3 (66) | Diesel | 1003,13 | | | | 44,9 | 31,2 | 14,4 | 44,9 | 31,2 | 14,4 | | | | 44,9 | 31,2 | 14,4 |
| POTIGUAR (53) | Diesel | 1003,14 | | | | 42,2 | 29,3 | 13,5 | 42,2 | 29,3 | 13,5 | | | | 42,2 | 29,3 | 13,5 |
| AREMBEPE (150) | Óleo | 1022,13 | | | | 125,0 | 125,0 | 125,0 | 125,0 | 125,0 | 125,0 | | | | 125,0 | 125,0 | 125,0 |
| MURICY (147) | Óleo | 1022,13 | | | | 108,0 | 108,0 | 108,0 | 108,0 | 108,0 | 108,0 | | | | 108,0 | 108,0 | 108,0 |
| GLOBAL I (149) | Óleo | 1042,47 | | | | 130,0 | 130,0 | 130,0 | 130,0 | 130,0 | 130,0 | | | | 130,0 | 130,0 | 130,0 |
| GLOBAL II (149) | Óleo | 1042,47 | | | | 130,0 | 130,0 | 130,0 | 130,0 | 130,0 | 130,0 | | | | 130,0 | 130,0 | 130,0 |
| PETROLINA (136) | Óleo | 1121,42 | | | | 132,0 | 132,0 | 132,0 | 132,0 | 132,0 | 132,0 | | | | 132,0 | 132,0 | 132,0 |
| PAU FERRO (94) | Diesel | 1135,63 | | | | 0,0 | 0,0 | 0,0 | 0,0 | 0,0 | 0,0 | | | | 0,0 | 0,0 | 0,0 |
| TERMOMANAU (143) | Diesel | 1135,63 | | | | 143,0 | 143,0 | 143,0 | 143,0 | 143,0 | 143,0 | | | | 143,0 | 143,0 | 143,0 |
| TOTAL NE (6889) | | | 806,1 | 806,1 | 806,1 | 3277,7 | 3248,6 | 3211,8 | 4083,8 | 4054,7 | 4017,9 | 0,0 | 0,0 | 0,0 | 4083,8 | 4054,7 | 4017,9 |

**REGIÃO NORTE**

| Térmicas Potência (MW) | Combustível | CVU (R$/MWh) | Inflexibilidade | | | Ordem de Mérito | | | Total Mérito e INFL. | | | Razão Elétrica | | | Total UTE | | |
|---|---|---|---|---|---|---|---|---|---|---|---|---|---|---|---|---|---|
| | | | P | M | L | P | M | L | P | M | L | P | M | L | P | M | L |
| C. ROCHA (85) | Gás | 0,00 | 65,0 | 65,0 | 65,0 | | | | 65,0 | 65,0 | 65,0 | | | | 65,0 | 65,0 | 65,0 |
| JARAQUI (75) | Gás | 0,00 | 63,0 | 63,0 | 63,0 | | | | 63,0 | 63,0 | 63,0 | | | | 63,0 | 63,0 | 63,0 |
| MANAUARA (67) | Gás | 0,00 | 64,5 | 64,5 | 64,5 | | | | 64,5 | 64,5 | 64,5 | | | | 64,5 | 64,5 | 64,5 |
| PONTA NEGR (66) | Gás | 0,00 | 64,0 | 64,0 | 64,0 | | | | 64,0 | 64,0 | 64,0 | | | | 64,0 | 64,0 | 64,0 |
| TAMBAQUI (93) | Gás | 0,00 | 63,0 | 63,0 | 63,0 | | | | 63,0 | 63,0 | 63,0 | | | | 63,0 | 63,0 | 63,0 |
| MARANHAO3 (519) | Gás | 85,72 | 494,8 | 515,3 | 512,7 | 0,0 | 0,0 | 0,0 | 494,8 | 515,3 | 512,7 | | | | 494,8 | 515,3 | 512,7 |
| APARECIDA (166) | Gás | 106,99 | 75,0 | 75,0 | 75,0 | 71,0 | 71,0 | 66,6 | 146,0 | 146,0 | 141,6 | | | | 146,0 | 146,0 | 141,6 |
| UTE MAUA 3 (591) | Gás | 106,99 | 264,0 | 264,0 | 264,0 | 326,8 | 326,8 | 326,8 | 590,8 | 590,8 | 590,8 | | | | 590,8 | 590,8 | 590,8 |
| PARNAIB_IV (56) | Gás | 151,69 | | | | 56,3 | 56,3 | 56,3 | 56,3 | 56,3 | 56,3 | | | | 56,3 | 56,3 | 56,3 |
| MARAN_VL_7 (336) | Gás | 209,81 | | | | 326,0 | 333,9 | 333,8 | 326,0 | 333,9 | 333,8 | | | | 326,0 | 333,9 | 333,8 |
| MARANIVL_7 (336) | Gás | 209,81 | | | | 325,9 | 334,9 | 333,7 | 325,9 | 334,9 | 333,7 | | | | 325,9 | 334,9 | 333,7 |
| MARAN_VL22 (1) | Gás | 209,82 | | | | 1,1 | 1,1 | 1,1 | 1,1 | 1,1 | 1,1 | | | | 1,1 | 1,1 | 1,1 |
| MARANIVL22 (1) | Gás | 209,82 | | | | 1,1 | 1,1 | 1,1 | 1,1 | 1,1 | 1,1 | | | | 1,1 | 1,1 | 1,1 |
| N.VEN2_L22 (27) | Gás | 232,27 | | | | 27,0 | 27,0 | 27,0 | 27,0 | 27,0 | 27,0 | | | | 27,0 | 27,0 | 27,0 |
| N.VEN2_L7 (151) | Gás | 232,27 | | | | 144,4 | 150,2 | 149,4 | 144,4 | 150,2 | 149,4 | | | | 144,4 | 150,2 | 149,4 |
| P. ITAQUI (360) | Carvão | 315,28 | | | | 360,1 | 272,8 | 156,3 | 360,1 | 272,8 | 156,3 | | | | 360,1 | 272,8 | 156,3 |
| GERAMAR1 (166) | Óleo | 920,02 | | | | 159,2 | 159,2 | 159,2 | 159,2 | 159,2 | 159,2 | | | | 159,2 | 159,2 | 159,2 |
| GERAMAR2 (166) | Óleo | 920,02 | | | | 159,2 | 159,2 | 159,2 | 159,2 | 159,2 | 159,2 | | | | 159,2 | 159,2 | 159,2 |
| TOTAL NORTE (3264) | | | 1153,3 | 1173,8 | 1171,2 | 1958,1 | 1893,5 | 1770,5 | 3111,4 | 3067,3 | 2941,7 | 0,0 | 0,0 | 0,0 | 3111,4 | 3067,3 | 2941,7 |

O conteúdo desta publicação foi produzido pelo ONS com base em dados e informações de conhecimento público. É de responsabilidade exclusiva dos agentes e demais interessados a obtenção de outros dados e informações, a realização de análises, estudos e avaliações para fins de tomada de decisões, definição de estratégias de atuação, assunção de compromissos e obrigações e quaisquer outras finalidades, em qualquer tempo e sob qualquer condição. É proibida a reprodução ou utilização total ou parcial do presente sem a identificação da fonte.