1. APRESENTAÇÃO

Na semana de 14/08 a 20/08/2021 houve chuva fraca no leste do Paraná, na bacia do Iguaçu e em pontos isolados da incremental a UHE Itaipu e do Paranapanema. Nas demais bacias hidrográficas de interesse do SIN permaneceu a estiagem.

Na semana operativa de 21/08 a 27/08/2021 deve ocorrer totais significativos de precipitação nas bacias dos rios Jacuí, Uruguai, Iguaçu e incremental a UHE de Itaipu.

Para a semana operativa de 21/08 a 27/08/2021, houve oferta de energia da República Oriental do Uruguai e da República da Argentina. De acordo com o Art. 2º da Portaria MME nº 339, de 15 de agosto de 2018, as ofertas para importação de energia não foram consideradas na elaboração do PMO.

Os valores médios semanais do Custo Marginal de Operação – CMO dos subsistemas do SIN sofreram as seguintes alterações em relação à semana anterior:

- SE/CO: de R$ 3.044,45/MWh para R$ 2.449,89/MWh
- Sul: de R$ 3.044,45/MWh para R$ 2.449,89/MWh
- Nordeste: de R$ 3.044,45/MWh para R$ 2.405,76/MWh
- Norte: de R$ 3.044,45/MWh para R$ 2.449,89/MWh

Desde o dia 01/01/2020, o despacho por ordem de mérito é indicado diariamente pelos resultados do modelo DESSEM. Assim, o despacho por ordem de mérito semanal, conforme publicado nesse documento, tem caráter apenas informativo. Da mesma forma, desde o dia 01/01/2021, a formação de preço deixou o formato semanal/patamar de carga e passou a ser horário, de acordo também com os resultados do modelo DESSEM.

2. NOTÍCIAS

Nos dias 26 e 27 de agosto será realizada a reunião de elaboração do PMO de Setembro de 2021, com transmissão ao vivo através do site do ONS.

Como medida adicional de prevenção ao Coronavírus, o ONS informa que está suspensa, temporariamente, a participação presencial nas reuniões.

3. ANÁLISE DAS CONDIÇÕES HIDROMETEOROLÓGICAS

3.1. PREVISÃO PARA A PRÓXIMA SEMANA

A passagem de uma frente fria pelos estados da região Sul ocasiona totais significativos de precipitação nas bacias dos rios Jacuí, Uruguai, Iguaçu e incremental a UHE de Itaipu (Figura 1).

O conteúdo desta publicação foi produzido pelo ONS com base em dados e informações de conhecimento público. É de responsabilidade exclusiva dos agentes e demais interessados a obtenção de outros dados e informações, a realização de análises, estudos e avaliações para fins de tomada de decisões, definição de estratégias de atuação, assunção de compromissos e obrigações e quaisquer outras finalidades, em qualquer tempo e sob qualquer condição. É proibida a reprodução ou utilização total ou parcial do presente sem a identificação da fonte.

Figura 1 - Precipitação acumulada prevista pelo modelo ECMWF (ECMWF) para o período de 21/08/2021 a 27/08/2021.

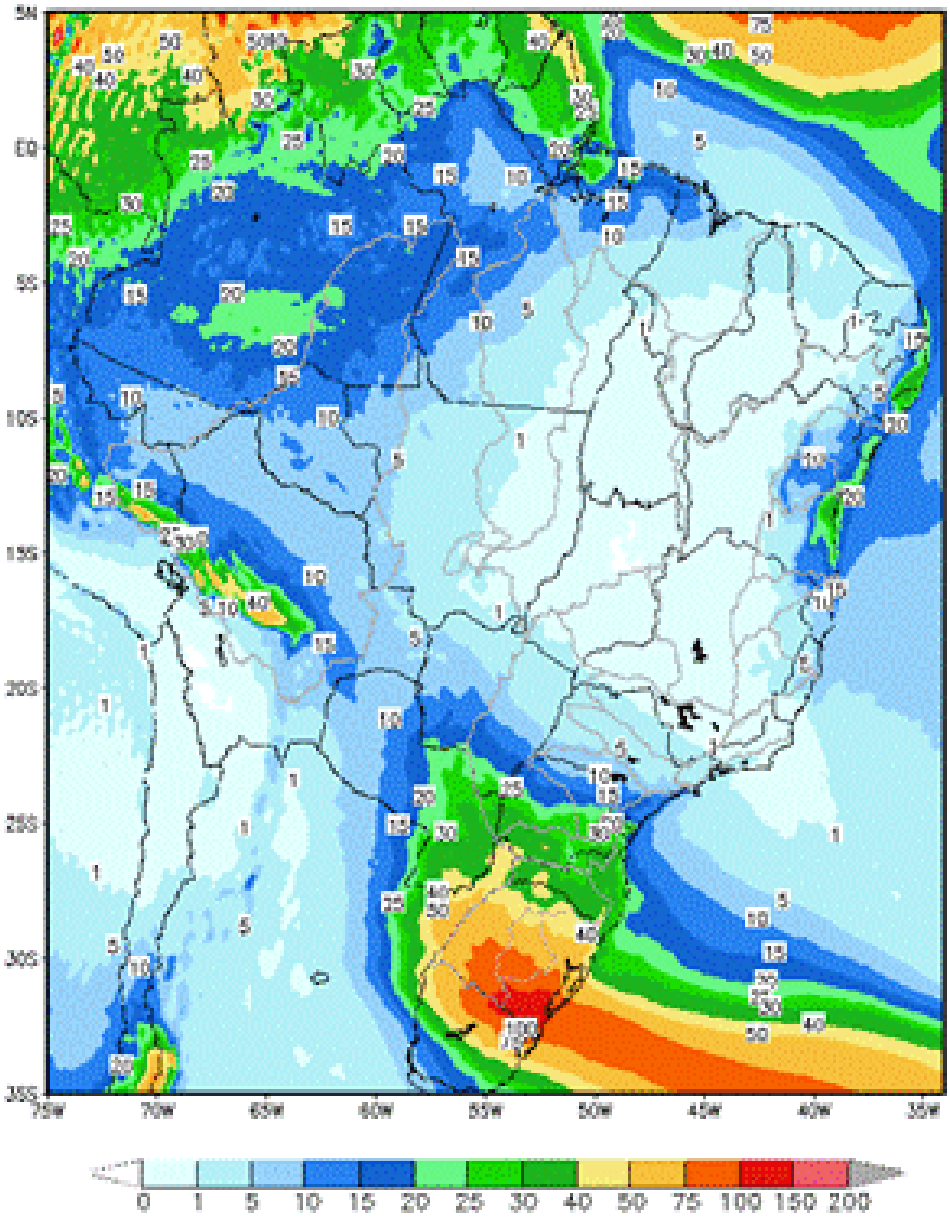

Em comparação com os valores estimados para a semana em curso, prevê-se para a próxima semana operativa recessão nas afluências dos subsistemas Sudeste/Centro-Oeste e Norte e estabilidade nas afluências dos subsistemas Sul e Nordeste. A previsão mensal para agosto indica a ocorrência de afluências abaixo da média histórica para todos os subsistemas.

Tabela 1 – Previsão de ENAs da Revisão 3 de agosto/2021

Revisão 3 do PMO de Agosto/2021 - ENAs previstas				
Subsistema	21/08 a 27/08/2021		Mês de agosto	
	MWmed	%MLT	MWmed	%MLT
SE/CO	11.169	54	12.158	59
S	3.744	37	3.632	36
NE	1.375	41	1.422	43
N	2.316	72	2.638	82

O conteúdo desta publicação foi produzido pelo ONS com base em dados e informações de conhecimento público. É de responsabilidade exclusiva dos agentes e demais interessados a obtenção de outros dados e informações, a realização de análises, estudos e avaliações para fins de tomada de decisões, definição de estratégias de atuação, assunção de compromissos e obrigações e quaisquer outras finalidades, em qualquer tempo e sob qualquer condição. É proibida a reprodução ou utilização total ou parcial do presente sem a identificação da fonte.

4. PREVISÃO DE CARGA

A diminuição das restrições locais em função do avanço na vacinação tem provocado uma melhora nas condições de demanda com impacto mais forte, que a esperada no início do ano, na recuperação da economia brasileira. O aumento recorde das vendas internacionais, tem estimulado a criação de empregos e o setor industrial tem se mantido em patamares elevados principalmente daquelas indústrias voltadas para exportação. Além disso, também tem contribuído para a recuperação, a melhora das atividades do setor de serviços, onde se concentra cerca de 70% do emprego gerado no país.

As sinalizações meteorológicas indicam para a próxima semana operativa nas capitais do subsistema Sudeste/Centro-Oeste a ocorrência de temperaturas elevadas e superiores às observadas na semana em curso. No subsistema Sul as previsões indicam a manutenção das temperaturas médias nas capitais desse subsistema, com exceção de Porto Alegre onde a previsão indica a passagem de uma frente fria que provoca queda das temperaturas no início da semana operativa.

Para as capitais do subsistema Nordeste são esperadas a ocorrência de temperaturas e condições do tempo sem variações em relação às últimas semanas, seguindo o comportamento típico para essa época do ano. No subsistema Norte destaca-se a suave redução de carga de alguns consumidores livres conectados à rede básica e a elevação das temperaturas médias em Manaus.

As taxas de crescimento previstas para o mês de agosto em relação ao mesmo mês do ano anterior, são de 1,6% para os subsistemas Sudeste/Centro-Oeste, 5,5% para o subsistema Sul, 7,4% no Nordeste e 4,2% no subsistema do Norte.

Tabela 2 – Evolução da carga do PMO de Agosto 2021

Subsistema	CARGA SEMANAL (MWmed)					CARGA MENSAL (MWmed)	
	1ª Sem	2ª Sem	3ª Sem	4ª Sem	5ª Sem	ago/21	Var. (%) ago/21 -> ago/20
SE/CO	36.446	37.399	38.347	39.286	38.918	38.051	1,6%
Sul	11.478	11.539	11.759	11.636	11.692	11.619	5,5%
Nordeste	10.899	11.068	11.161	11.157	11.166	11.089	7,4%
Norte	5.933	6.041	6.127	6.144	6.174	6.080	4,2%
SIN	64.756	66.047	67.394	68.223	67.950	66.838	3,4%

O conteúdo desta publicação foi produzido pelo ONS com base em dados e informações de conhecimento público. É de responsabilidade exclusiva dos agentes e demais interessados a obtenção de outros dados e informações, a realização de análises, estudos e avaliações para fins de tomada de decisões, definição de estratégias de atuação, assunção de compromissos e obrigações e quaisquer outras finalidades, em qualquer tempo e sob qualquer condição. É proibida a reprodução ou utilização total ou parcial do presente sem a identificação da fonte.

5. PRINCIPAIS RESULTADOS

5.1. CUSTO MARGINAL DE OPERAÇÃO (CMO)

A tabela a seguir apresenta o CMO, por subsistema e patamar de carga para próxima semana operativa.

Tabela 3 – CMO por patamar de carga

Patamares de Carga	CMO (R$/MWh)			
	SE/CO	S	NE	N
Pesada	2.509,70	2.509,70	2.509,70	2.509,70
Média	2.496,05	2.496,05	2.496,05	2.496,05
Leve	2.381,73	2.381,73	2.282,88	2.381,73
Média Semanal	2.449,89	2.449,89	2.405,76	2.449,89

Na figura a seguir é apresentada a evolução do CMO médio semanal ao longo deste PMO.

Figura 2 – Evolução semanal do CMO

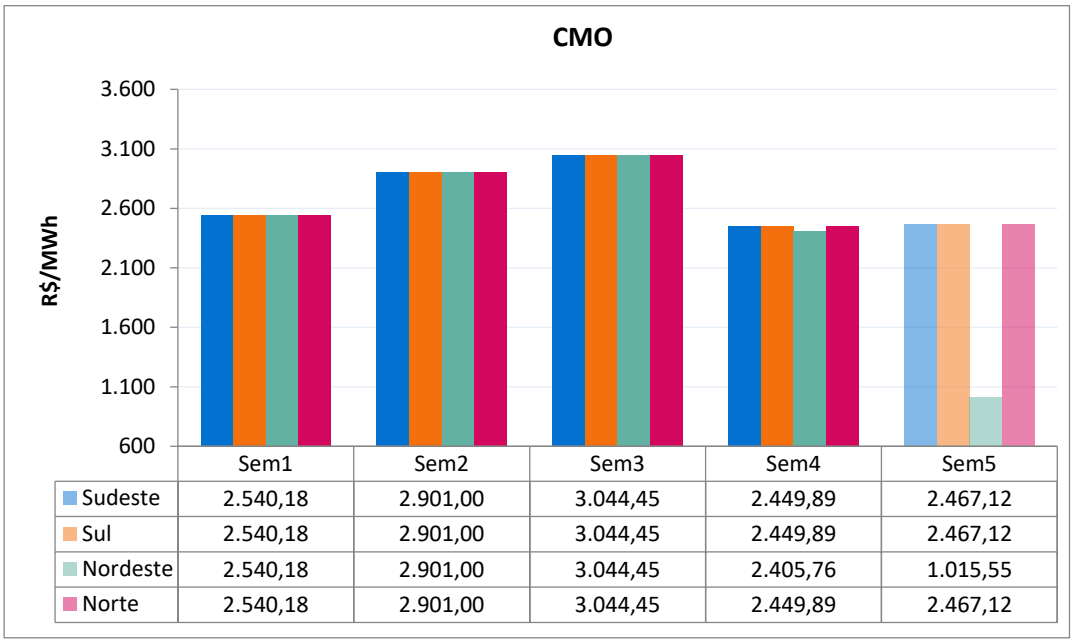

5.2. POLÍTICA DE OPERAÇÃO ENERGÉTICA

Para esta semana operativa, está prevista a seguinte política de intercâmbio de energia entre regiões:

Região SE/CO → Geração minimizada de acordo com os condicionantes hidráulicos.

Região Sul → Geração dimensionada para fechamento do balanço energético do SIN.

Região NE → Aumento da geração eólica e exportação de energia, modulando em função de seus recursos energéticos, respeitando-se os limites elétricos vigentes.

Região Norte → Redução da exploração das disponibilidades energéticas, respeitando-se os limites elétricos vigentes.

O conteúdo desta publicação foi produzido pelo ONS com base em dados e informações de conhecimento público. É de responsabilidade exclusiva dos agentes e demais interessados a obtenção de outros dados e informações, a realização de análises, estudos e avaliações para fins de tomada de decisões, definição de estratégias de atuação, assunção de compromissos e obrigações e quaisquer outras finalidades, em qualquer tempo e sob qualquer condição. É proibida a reprodução ou utilização total ou parcial do presente sem a identificação da fonte.

6. ANÁLISE DA VARIAÇÃO SEMANAL DO CMO

Esta análise visa identificar os principais parâmetros cujas atualizações impactaram os CMO deste PMO, em comparação com os valores obtidos na última revisão.

Foram realizados 8 estudos, onde o caso inicial foi construído com base nos dados oficiais da última revisão deste PMO. Neste primeiro estudo, denominado de "previsão perfeita", a partida dos reservatórios foi estimada conforme indicado para esta semana na última revisão.

O segundo estudo foi realizado com os dados do caso inicial sendo substituída a previsão de vazões.

A partir do conjunto de dados do segundo estudo foram elaborados os demais casos em que foram atualizadas, sequencialmente, as seguintes informações: níveis de partida dos reservatórios, previsão de carga, disponibilidade das usinas térmicas e hidráulicas, restrições de limites de intercâmbio, restrições hidráulicas e, por fim, os demais dados que compõem toda informação referente a atual revisão.

A forte redução do CMO desta semana em relação aos valores da semana passada foi ocasionada, principalmente, pela atualização da previsão de vazões, conforme pode ser observado na Figura 3. A atualização dos níveis de partida e disponibilidade das usinas também contribuíram para a redução do CMO. Os subsistemas SE/CO, S, NE e N estão com CMO acoplados nos patamares de carga pesada e média. No patamar de carga leve, apenas o subsistema NE apresentou valores inferiores aos demais subsistemas.

Figura 3 – Análise da variação do CMO nos subsistemas SE/CO, S e N

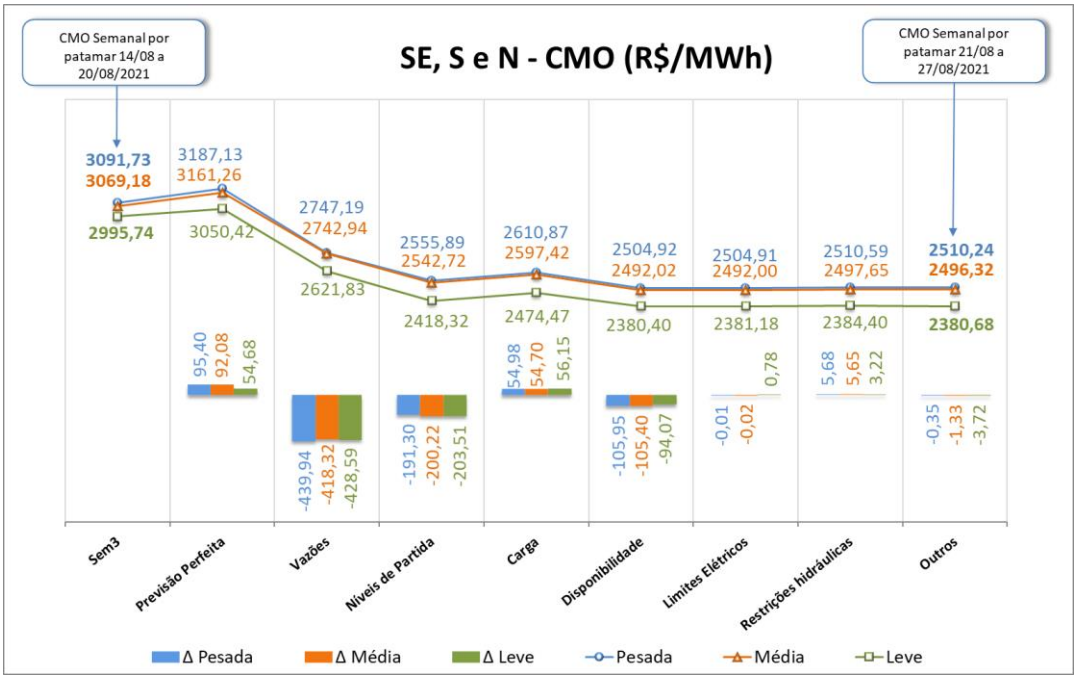

O conteúdo desta publicação foi produzido pelo ONS com base em dados e informações de conhecimento público. É de responsabilidade exclusiva dos agentes e demais interessados a obtenção de outros dados e informações, a realização de análises, estudos e avaliações para fins de tomada de decisões, definição de estratégias de atuação, assunção de compromissos e obrigações e quaisquer outras finalidades, em qualquer tempo e sob qualquer condição. É proibida a reprodução ou utilização total ou parcial do presente sem a identificação da fonte.

7. GERAÇÃO TÉRMICA

A Figura 4 apresenta, para cada subsistema, o despacho térmico por modalidade indicado pelo Decomp para a próxima semana operativa.

Figura 4 – Geração térmica para a próxima semana operativa

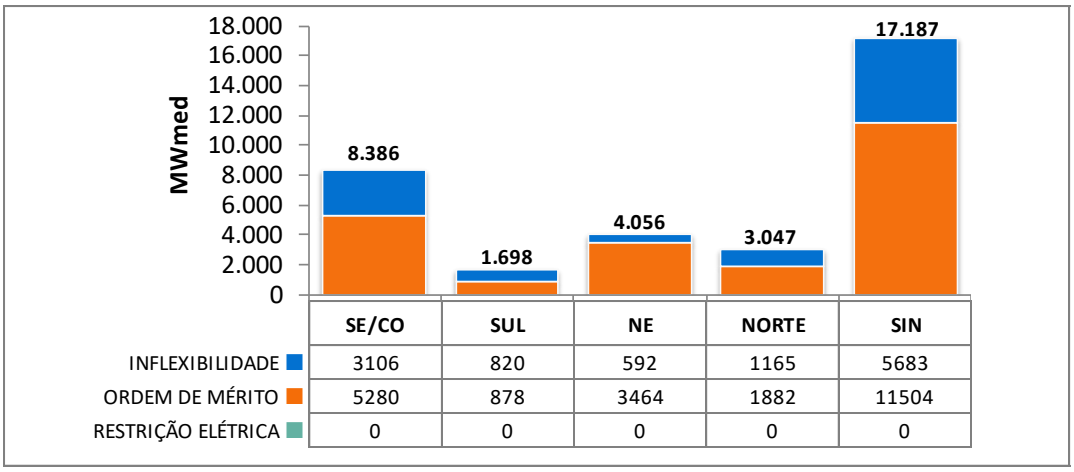

	SE/CO	SUL	NE	NORTE	SIN
INFLEXIBILIDADE	3106	820	592	1165	5683
ORDEM DE MÉRITO	5280	878	3464	1882	11504
RESTRIÇÃO ELÉTRICA	0	0	0	0	0

Na tabela abaixo segue a Indicação de despacho antecipado por ordem de mérito de custo para a semana de 23/10/2021 a 29/10/2021.

Tabela 4 – UTEs com contrato de combustível GNL

UTE			Benefício (R$/MWh)		
Nome	Cod	CVU (R$/MWh)	Carga Pesada	Carga Média	Carga Leve
SANTA CRUZ	86	259,44	1455,93 (1)	1455,93 (1)	1454,91 (1)
LUIZORMELO	15	399,11	1455,93 (1)	1455,93 (1)	1454,91 (1)
PSERGIPE I	224	321,29	332,38 (1)	332,31 (1)	332,30 (1)

(1) Comandado o despacho antecipado por ordem de mérito de custo nesse patamar

(2) NÃO foi comandado o despacho antecipado por ordem de mérito de custo nesse patamar

Assim sendo, há previsão de despacho antecipado por ordem de mérito de custo para as UTE Santa Cruz, Luiz O. R. Melo e Porto Sergipe I, para a semana de 23/10 a 29/10/2021.

O conteúdo desta publicação foi produzido pelo ONS com base em dados e informações de conhecimento público. É de responsabilidade exclusiva dos agentes e demais interessados a obtenção de outros dados e informações, a realização de análises, estudos e avaliações para fins de tomada de decisões, definição de estratégias de atuação, assunção de compromissos e obrigações e quaisquer outras finalidades, em qualquer tempo e sob qualquer condição. É proibida a reprodução ou utilização total ou parcial do presente sem a identificação da fonte.

8. IMPORTAÇÃO DE ENERGIA DA REPÚBLICA ORIENTAL DO URUGUAI

8.1. República Oriental do Uruguai

Para a próxima semana operativa, foram declaradas as seguintes ofertas de importação de energia da República Oriental do Uruguai para o Sistema Interligado Nacional - SIN através das conversoras de Rivera (70 MW) e Melo (500 MW).

- **Eletrobras**

Tabela 5 – Energia ofertada para importação

	Oferta de Energia para a Semana de 21/08 a 27/08 (MWmed)				
	Bloco 1	Bloco 2	Bloco 3	Bloco 4	Total
Carga Pesada	100	50	85	50	285
Carga Média	100	50	85	50	285
Carga Leve	100	50	85	50	285
CVU (R$/MWh)	950,40	1.386,38	1.751,98	1.944,28	

- **Enel**

Conforme declaração do agente, esta importação poderá ser realizada exclusivamente pela conversora Melo.

Tabela 6 – Energia ofertada para importação

	Oferta de Energia para a Semana de 21/08 a 27/08 (MWmed)				
	Bloco 1	Bloco 2	Bloco 3	Bloco 4	Total
Carga Pesada	100	50	85	50	285
Carga Média	100	50	85	50	285
Carga Leve	100	50	85	50	285
CVU (R$/MWh)	968,72	1.415,53	1.790,91	1.988,48	

8.2. República da Argentina

- **Enel**

Para a próxima semana operativa, foi declarada a seguinte oferta de importação de energia da República da Argentina para o SIN através das conversoras de Garabi 1 (1.100 MW) e Garabi 2 (1.100 MW).

Tabela 7 – Energia ofertada para importação

	Oferta de Energia para a Semana de 21/08 a 27/08 (MWmed)					
	Bloco 1	Bloco 2	Bloco 3	Bloco 4	Bloco 5	Total
Carga Pesada	200	400	600	600	400	2.200
Carga Média	200	400	600	600	400	2.200
Carga Leve	200	400	600	600	400	2.200
CVU (R$/MWh)	1.367,83	1.432,27	1.564,04	1.630,22	1.895,50	

Nota: Detalhes sobre a importação de energia vide Portaria Nº 339, de 15 de agosto de 2018 disponível em: http://pesquisa.in.gov.br/imprensa/jsp/visualiza/index.jsp?data=17/08/2018&jornal=515&pagina=60&totalArquivos=136

O conteúdo desta publicação foi produzido pelo ONS com base em dados e informações de conhecimento público. É de responsabilidade exclusiva dos agentes e demais interessados a obtenção de outros dados e informações, a realização de análises, estudos e avaliações para fins de tomada de decisões, definição de estratégias de atuação, assunção de compromissos e obrigações e quaisquer outras finalidades, em qualquer tempo e sob qualquer condição. É proibida a reprodução ou utilização total ou parcial do presente sem a identificação da fonte.

9. ARMAZENAMENTOS OPERATIVOS

Para uma melhor avaliação de diversos cenários hidrometeorológicos, notadamente, aqueles de curto prazo e suas influências nas previsões de vazões nos subsistemas, os resultados desta revisão do PMO contemplam cenários de afluências visando melhor representar a ocorrência de precipitação e, consequentemente, seus efeitos sobre as afluências e armazenamentos.

Além dos resultados associados ao valor esperado das previsões de afluências, as simulações operativas também foram realizadas com os limites superior e inferior das previsões de afluências. Apresentamos a seguir os resultados obtidos com a aplicação dos diferentes cenários de afluência.

Tabela 8 – Previsão de ENA dos cenários de sensibilidade

Subsistema	ENERGIAS NATURAIS AFLUENTES					
	Previsão Mensal					
	LI		VE		LS	
	(MWmed)	%MLT	(MWmed)	%MLT	(MWmed)	%MLT
SE/CO	11.613	**56**	12.158	**59**	12.701	**62**
Sul	2.810	**28**	3.632	**36**	4.447	**44**
Nordeste	1.371	**41**	1.422	**43**	1.474	**44**
Norte	2.550	**79**	2.638	**82**	2.725	**85**

Tabela 9 – Previsão de %EARmáx para o final do mês

Subsistema	% EARmáx 20/08	% EARmáx - 31/08		
	NÍVEL INICIAL	NÍVEL PMO		
	VE	LI	VE	LS
SE/CO	23,4	21,2	21,7	22,0
Sul	33,8	24,8	26,8	29,2
Nordeste	51,3	48,8	49,0	49,1
Norte	74,5	71,8	72,4	72,5

O conteúdo desta publicação foi produzido pelo ONS com base em dados e informações de conhecimento público. É de responsabilidade exclusiva dos agentes e demais interessados a obtenção de outros dados e informações, a realização de análises, estudos e avaliações para fins de tomada de decisões, definição de estratégias de atuação, assunção de compromissos e obrigações e quaisquer outras finalidades, em qualquer tempo e sob qualquer condição. É proibida a reprodução ou utilização total ou parcial do presente sem a identificação da fonte.

10. RESERVATÓRIOS EQUIVALENTES DE ENERGIA

A seguir são apresentadas as previsões de Energia Natural Afluente para a próxima semana operativa e para o mês de agosto, bem como as previsões de Energia Armazenada nos Reservatórios Equivalentes de Energia – REE, desta revisão do PMO.

Tabela 10 – Previsão de ENA por REE

Valor Esperado das Energias Naturais Afluentes				
REE	Previsão Semanal		Previsão Mensal	
	21/08/2021 a 27/08/2021		ago/21	
	(MWmed)	%MLT	(MWmed)	%MLT
Sudeste	1.471	60	1.557	64
Madeira	1.347	56	1.632	68
Teles Pires	532	69	576	74
Itaipu	1.749	67	1.862	71
Paraná	5.267	50	5.663	54
Paranapanema	785	42	851	45
Sul	2.121	36	2.116	36
Iguaçu	1.624	40	1.515	37
Nordeste	1.375	41	1.422	43
Norte	1.054	57	1.169	64
Belo Monte	205	30	354	53
Manaus	1.060	151	1.158	165

Tabela 11 – Previsão de %EARmáx por REE

% Energia Armazenável Máxima		
REE	Previsão Semanal	Previsão Mensal
	27-ago	31-ago
	(%EARmáx)	(%EARmáx)
Sudeste	30,4	29,5
Madeira	45,2	39,7
Teles Pires	57,2	52,7
Itaipu	34,4	47,4
Paraná	17,9	17,3
Paranapanema	35,0	35,3
Sul	35,2	33,4
Iguaçu	22,9	20,9
Nordeste	49,9	49,0
Norte	72,3	71,6
Belo Monte	94,0	91,5
Manaus	90,3	88,4

O conteúdo desta publicação foi produzido pelo ONS com base em dados e informações de conhecimento público. É de responsabilidade exclusiva dos agentes e demais interessados a obtenção de outros dados e informações, a realização de análises, estudos e avaliações para fins de tomada de decisões, definição de estratégias de atuação, assunção de compromissos e obrigações e quaisquer outras finalidades, em qualquer tempo e sob qualquer condição. É proibida a reprodução ou utilização total ou parcial do presente sem a identificação da fonte.

11. DESPACHO TÉRMICO POR MODALIDADE, PATAMAR DE CARGA E USINA

Nas tabelas abaixo, a diferenciação entre geração por inflexibilidade e por ordem de mérito tem caráter informativo, com o objetivo de detalhar a informação de inflexibilidade enviada pelos respectivos agentes para esta revisão do PMO. Ressalta-se que nas etapas de Programação Diária e Tempo Real, o montante despachado nas usinas termelétricas indicadas por ordem de mérito é plenamente intitulado como ordem de mérito.

REGIÃO SUDESTE/CENTRO-OESTE

Térmicas Potência (MW)	Combustível	CVU (R$/MWh)	Inflexibilidade			Ordem de Mérito			Total Mérito e INFL.			Razão Elétrica			Total UTE		
			P	M	L	P	M	L	P	M	L	P	M	L	P	M	L
ATLAN_CSA (255)	Resíduos	0,00	178,0	178,0	178,0				178,0	178,0	178,0				178,0	178,0	178,0
ANGRA 2 (1350)	Nuclear	20,12	1350,0	1350,0	1350,0	0,0	0,0	0,0	1350,0	1350,0	1350,0				1350,0	1350,0	1350,0
ANGRA 1 (640)	Nuclear	31,17	640,0	640,0	640,0	0,0	0,0	0,0	640,0	640,0	640,0				640,0	640,0	640,0
NORTEFLU 1 (400)	Gás	80,11	400,0	400,0	400,0	0,0	0,0	0,0	400,0	400,0	400,0				400,0	400,0	400,0
NORTEFLU 2 (100)	Gás	92,32	100,0	100,0	100,0	0,0	0,0	0,0	100,0	100,0	100,0				100,0	100,0	100,0
O.PINTADA (50)	Biomassa	112,47	5,0	5,0	5,0	45,0	45,0	45,0	50,0	50,0	50,0				50,0	50,0	50,0
UTE STA VI (41)	Biomassa	121,49	13,0	13,0	13,0	28,4	28,4	28,4	41,4	41,4	41,4				41,4	41,4	41,4
PREDILECTA (5)	Biomassa	158,95	1,0	1,0	1,0	4,0	4,0	4,0	5,0	5,0	5,0				5,0	5,0	5,0
NORTEFLU 3 (200)	Gás	174,85	200,0	200,0	200,0	0,0	0,0	0,0	200,0	200,0	200,0				200,0	200,0	200,0
ATLANTICO (235)	Resíduos	204,31	218,7	218,7	218,7	0,0	0,0	0,0	218,7	218,7	218,7				218,7	218,7	218,7
BAIXADA FL (530)	Gás	255,86				530,0	530,0	530,0	530,0	530,0	530,0				530,0	530,0	530,0
SANTA CRUZ (500)	GNL	259,44				350,0	350,0	350,0	350,0	350,0	350,0				350,0	350,0	350,0
T.LAGOAS (350)	Gás	262,77				270,0	270,0	270,0	270,0	270,0	270,0				270,0	270,0	270,0
JUIZ DE FO (87)	Gás	283,74				84,8	84,8	84,8	84,8	84,8	84,8				84,8	84,8	84,8
ST.CRUZ 34 (436)	Óleo	310,41															
TERMORIO (1036)	Gás	330,06				610,0	610,0	610,0	610,0	610,0	610,0				610,0	610,0	610,0
CUBATAO (216)	Gás	353,47				209,0	209,0	209,0	209,0	209,0	209,0				209,0	209,0	209,0
LUIZORMELO (204)	GNL	399,11				200,0	200,0	200,0	200,0	200,0	200,0				200,0	200,0	200,0
SEROPEDICA (386)	Gás	410,96				353,5	353,5	353,5	353,5	353,5	353,5				353,5	353,5	353,5
PIRAT.12 O (200)	Gás	470,34															
NPIRATINGA (572)	Gás	548,04				545,6	545,6	545,6	545,6	545,6	545,6				545,6	545,6	545,6
NORTEFLU 4 (127)	Gás	604,34				126,0	126,0	126,0	126,0	126,0	126,0				126,0	126,0	126,0
CUIABA CC (529)	Gás	701,88				490,0	490,0	490,0	490,0	490,0	490,0				490,0	490,0	490,0
T.MACAE (929)	Gás	739,19				839,0	839,0	839,0	839,0	839,0	839,0				839,0	839,0	839,0
PALMEIR_GO (176)	Diesel	763,38				0,0	0,0	0,0	0,0	0,0	0,0				0,0	0,0	0,0
IBIRITE (226)	Gás	781,76				222,0	222,0	222,0	222,0	222,0	222,0				222,0	222,0	222,0
TNORTE 2 (340)	Óleo	910,86				0,0	0,0	0,0	0,0	0,0	0,0				0,0	0,0	0,0
VIANA (175)	Óleo	960,28				174,6	174,6	174,6	174,6	174,6	174,6				174,6	174,6	174,6
CAMPOS (25)	Gás	978,10															
DAIA (44)	Diesel	1019,93				0,0	0,0	0,0	0,0	0,0	0,0				0,0	0,0	0,0
GOIANIA 2 (140)	Diesel	1066,64				0,0	0,0	0,0	0,0	0,0	0,0				0,0	0,0	0,0
XAVANTES (54)	Diesel	1465,79				53,5	53,5	53,5	53,5	53,5	53,5				53,5	53,5	53,5
W.ARJONA (177)	Gás	2075,36				144,1	144,1	144,1	144,1	144,1	144,1				144,1	144,1	144,1
TOTAL SE/CO (10735)			3105,7	3105,7	3105,7	5279,5	5279,5	5279,5	8385,2	8385,2	8385,2	0,0	0,0	0,0	8385,2	8385,2	8385,2

REGIÃO SUL

Térmicas Potência (MW)	Combustível	CVU (R$/MWh)	Inflexibilidade			Ordem de Mérito			Total Mérito e INFL.			Razão Elétrica			Total UTE		
			P	M	L	P	M	L	P	M	L	P	M	L	P	M	L
URUGUAIANA (640)	Gás	---															
PAMPA SUL (345)	Carvão	69,75				0,0	0,0	0,0	0,0	0,0	0,0				0,0	0,0	0,0
SAO SEPE (8)	Biomassa	87,75	8,0	8,0	8,0	0,0	0,0	0,0	8,0	8,0	8,0				8,0	8,0	8,0
CANDIOTA_3 (350)	Carvão	91,59	310,0	310,0	310,0	0,0	0,0	0,0	310,0	310,0	310,0				310,0	310,0	310,0
J.LACER. C (363)	Carvão	229,27	200,0	200,0	200,0	130,0	130,0	130,0	330,0	330,0	330,0				330,0	330,0	330,0
J.LACER. B (262)	Carvão	271,21	160,0	160,0	160,0	60,0	60,0	60,0	220,0	220,0	220,0				220,0	220,0	220,0
J.LAC. A2 (132)	Carvão	278,38	70,0	70,0	70,0	40,0	40,0	40,0	110,0	110,0	110,0				110,0	110,0	110,0
J.LAC. A1 (100)	Carvão	304,61	70,0	70,0	70,0	10,0	10,0	10,0	80,0	80,0	80,0				80,0	80,0	80,0
MADEIRA (4)	Biomassa	325,32	2,0	2,0	2,0	1,0	1,0	1,0	3,0	3,0	3,0				3,0	3,0	3,0
FIGUEIRA (20)	Carvão	475,68				0,0	0,0	0,0	0,0	0,0	0,0				0,0	0,0	0,0
CANOAS (249)	Diesel	698,14				243,1	243,1	243,1	243,1	243,1	243,1				243,1	243,1	243,1
ARAUCARIA (484)	Gás	1083,21				420,0	402,0	369,0	420,0	402,0	369,0				420,0	402,0	369,0
TOTAL SUL (2957)			820,0	820,0	820,0	904,1	886,1	853,1	1724,1	1706,1	1673,1	0,0	0,0	0,0	1724,1	1706,1	1673,1

O conteúdo desta publicação foi produzido pelo ONS com base em dados e informações de conhecimento público. É de responsabilidade exclusiva dos agentes e demais interessados a obtenção de outros dados e informações, a realização de análises, estudos e avaliações para fins de tomada de decisões, definição de estratégias de atuação, assunção de compromissos e obrigações e quaisquer outras finalidades, em qualquer tempo e sob qualquer condição. É proibida a reprodução ou utilização total ou parcial do presente sem a identificação da fonte.

REGIÃO NORDESTE

Térmicas Potência (MW)	Combustível	CVU (R$/MWh)	Inflexibilidade			Ordem de Mérito			Total Mérito e INFL.			Razão Elétrica			Total UTE		
			P	M	L	P	M	L	P	M	L	P	M	L	P	M	L
ALTOS (13)	Diesel	---															
ARACATI (11)	Diesel	---															
BATURITE (11)	Diesel	---															
C.MAIOR (13)	Diesel	---															
CAUCAIA (15)	Diesel	---															
CRATO (13)	Diesel	---															
IGUATU (15)	Diesel	---															
JUAZEIRO N (15)	Diesel	---															
MARAMBAIA (13)	Diesel	---															
NAZARIA (13)	Diesel	---															
PECEM (15)	Diesel	---															
ERB CANDEI (17)	Biomassa	87,81	2,7	3,5	4,1	3,9	5,2	5,9	6,6	8,7	10,0				6,6	8,7	10,0
PROSPERIDA (28)	Gás	165,61				28,0	28,0	28,0	28,0	28,0	28,0				28,0	28,0	28,0
TERMOPE (533)	Gás	168,43	532,7	532,7	532,7	0,0	0,0	0,0	532,7	532,7	532,7				532,7	532,7	532,7
FORTALEZA (327)	Gás	245,46				255,9	267,2	296,1	255,9	267,2	296,1				255,9	267,2	296,1
PSERGIPE I (1516)	GNL	321,29															
P.PECEM2 (365)	Carvão	395,03		55,1	99,7	365,0	309,7	260,3	365,0	364,8	360,0				365,0	364,8	360,0
P.PECEM1 (720)	Carvão	396,09				720,0	720,0	720,0	720,0	720,0	720,0				720,0	720,0	720,0
TERMOCEARA (223)	Gás	431,81				0,0	0,0	0,0	0,0	0,0	0,0				0,0	0,0	0,0
SYKUE I (30)	Biomassa	510,12				0,0	0,0	0,0	0,0	0,0	0,0				0,0	0,0	0,0
BAHIA_1 (31)	Óleo	819,14				26,0	26,0	26,0	26,0	26,0	26,0				26,0	26,0	26,0
PERNAMBU_3 (201)	Óleo	828,69				0,0	0,0	0,0	0,0	0,0	0,0				0,0	0,0	0,0
VALE ACU (368)	Gás	829,28				110,0	110,0	110,0	110,0	110,0	110,0				110,0	110,0	110,0
T.BAHIA (186)	Gás	854,01				158,9	158,9	158,9	158,9	158,9	158,9				158,9	158,9	158,9
MARACANAU (168)	Óleo	934,51				121,0	121,0	121,0	121,0	121,0	121,0				121,0	121,0	121,0
TERMOCABO (50)	Óleo	948,48				33,1	33,1	33,1	33,1	33,1	33,1				33,1	33,1	33,1
TERMONE (171)	Óleo	951,70				160,0	160,0	160,0	160,0	160,0	160,0				160,0	160,0	160,0
TERMOPB (171)	Óleo	951,70				154,0	154,0	154,0	154,0	154,0	154,0				154,0	154,0	154,0
CAMPINA_GR (169)	Óleo	960,30				135,0	135,0	135,0	135,0	135,0	135,0				135,0	135,0	135,0
SUAPE II (381)	Óleo	982,95				353,9	347,5	332,8	353,9	347,5	332,8				353,9	347,5	332,8
POTIGUAR_3 (66)	Diesel	1003,13				30,8	21,1	12,0	30,8	21,1	12,0				30,8	21,1	12,0
POTIGUAR (53)	Diesel	1003,14				31,5	21,6	12,3	31,5	21,6	12,3				31,5	21,6	12,3
AREMBEPE (150)	Óleo	1022,13				125,0	125,0	125,0	125,0	125,0	125,0				125,0	125,0	125,0
MURICY (147)	Óleo	1022,13				108,0	105,4	79,2	108,0	105,4	79,2				108,0	105,4	79,2
GLOBAL I (149)	Óleo	1087,89				130,0	130,0	130,0	130,0	130,0	130,0				130,0	130,0	130,0
GLOBAL II (149)	Óleo	1087,89				130,0	130,0	130,0	130,0	130,0	130,0				130,0	130,0	130,0
PETROLINA (136)	Óleo	1121,42				128,0	128,0	128,0	128,0	128,0	128,0				128,0	128,0	128,0
PAU FERRO (94)	Diesel	1135,63				94,0	94,0	94,0	94,0	94,0	94,0				94,0	94,0	94,0
TERMOMANAU (143)	Diesel	1135,63				143,0	143,0	143,0	143,0	143,0	143,0				143,0	143,0	143,0
TOTAL NE (6889)			535,4	591,3	636,5	3545,0	3473,7	3394,6	4080,4	4065,0	4031,1	0,0	0,0	0,0	4080,4	4065,0	4031,1

REGIÃO NORTE

Térmicas Potência (MW)	Combustível	CVU (R$/MWh)	Inflexibilidade			Ordem de Mérito			Total Mérito e INFL.			Razão Elétrica			Total UTE		
			P	M	L	P	M	L	P	M	L	P	M	L	P	M	L
C. ROCHA (85)	Gás	0,00	65,0	65,0	65,0				65,0	65,0	65,0				65,0	65,0	65,0
JARAQUI (75)	Gás	0,00	63,0	63,0	63,0				63,0	63,0	63,0				63,0	63,0	63,0
MANAUARA (67)	Gás	0,00	64,5	64,5	64,5				64,5	64,5	64,5				64,5	64,5	64,5
PONTA NEGR (66)	Gás	0,00	64,0	64,0	64,0				64,0	64,0	64,0				64,0	64,0	64,0
TAMBAQUI (93)	Gás	0,00	63,0	63,0	63,0				63,0	63,0	63,0				63,0	63,0	63,0
MARANHAO3 (519)	Gás	85,72	494,8	515,3	512,7	0,0	0,0	0,0	494,8	515,3	512,7				494,8	515,3	512,7
APARECIDA (166)	Gás	118,96	75,0	75,0	75,0	71,0	70,1	70,6	146,0	145,1	145,6				146,0	145,1	145,6
UTE MAUA 3 (591)	Gás	118,96	264,0	264,0	264,0	326,8	250,5	158,9	590,8	514,5	422,9				590,8	514,5	422,9
PARNAIB_IV (56)	Gás	151,69				56,3	56,3	56,3	56,3	56,3	56,3				56,3	56,3	56,3
N.VEN2_L22 (27)	Gás	232,27				27,0	27,0	27,0	27,0	27,0	27,0				27,0	27,0	27,0
N.VEN2_L7 (151)	Gás	232,27				144,4	150,2	149,4	144,4	150,2	149,4				144,4	150,2	149,4
MARAN_VL_7 (336)	Gás	238,24				326,0	334,9	333,8	326,0	334,9	333,8				326,0	334,9	333,8
MARANIVL_7 (336)	Gás	238,24				325,9	334,9	333,7	325,9	334,9	333,7				325,9	334,9	333,7
MARAN_VL22 (1)	Gás	238,25				1,1	1,1	1,1	1,1	1,1	1,1				1,1	1,1	1,1
MARANIVL22 (1)	Gás	238,25				1,1	1,1	1,1	1,1	1,1	1,1				1,1	1,1	1,1
P. ITAQUI (360)	Carvão	388,25				360,1	360,1	360,1	360,1	360,1	360,1				360,1	360,1	360,1
GERAMAR1 (166)	Óleo	960,26				159,2	159,2	159,2	159,2	159,2	159,2				159,2	159,2	159,2
GERAMAR2 (166)	Óleo	960,26				159,2	159,2	159,2	159,2	159,2	159,2				159,2	159,2	159,2
TOTAL NORTE (3264)			1153,3	1173,8	1171,2	1958,1	1904,6	1810,4	3111,4	3078,4	2981,6	0,0	0,0	0,0	3111,4	3078,4	2981,6

O conteúdo desta publicação foi produzido pelo ONS com base em dados e informações de conhecimento público. É de responsabilidade exclusiva dos agentes e demais interessados a obtenção de outros dados e informações, a realização de análises, estudos e avaliações para fins de tomada de decisões, definição de estratégias de atuação, assunção de compromissos e obrigações e quaisquer outras finalidades, em qualquer tempo e sob qualquer condição. É proibida a reprodução ou utilização total ou parcial do presente sem a identificação da fonte.