1. APRESENTAÇÃO

Durante a semana de 11/09 a 17/09/2021 houve precipitação nas bacias dos rios Jacuí, Uruguai, Iguaçu, Paranapanema e no trecho incremental a UHE Itaipu. Nas demais bacias hidrográficas de interesse do SIN permaneceu a estiagem.

Para a semana de 18/09 a 24/09/2021 espera-se fraca precipitação nas bacias dos rios Jacuí, Uruguai e Iguaçu, além de chuviscos em pontos isolados da bacia do rio Paranapanema e do trecho incremental a UHE Itaipu.

Para a semana operativa de 18/09 a 24/09/2021, houve oferta de energia da República Oriental do Uruguai e da República da Argentina. De acordo com o Art. 2º da Portaria MME nº 339, de 15 de agosto de 2018, as ofertas para importação de energia não foram consideradas na elaboração do PMO.

Os valores médios semanais do Custo Marginal de Operação – CMO dos subsistemas do SIN sofreram as seguintes alterações em relação à semana anterior:

- SE/CO: de R$ 868,30/MWh para R$ 712,80/MWh
- Sul: de R$ 868,30/MWh para R$ 712,80/MWh
- Nordeste: de R$ 868,30/MWh para R$ 712,40/MWh
- Norte: de R$ 868,30/MWh para R$ 712,80/MWh

A Câmara de Regras Excepcionais para Gestão Hidroenergética (CREG), em sua 5ª Reunião (Extraordinária) realizada em 31/08/2021, determinou ao ONS, concessionários e autorizados de geração de energia elétrica, de forma imediata e com vigência até o final de novembro de 2021, que operem os correspondentes reservatórios até o limite físico de exploração energética, mediante flexibilização de regras operativas que estabeleçam níveis mínimos de armazenamento, resguardados os usos prioritários de que trata o inciso III do art. 1º da Lei nº 9.433/1997.

A partir do dia 14/09/2021, o reservatório da UHE Ilha Solteira passou a operar com cotas inferiores à sua cota mínima operativa oficial, assim como o reservatório da UHE Três Irmãos, em 15/09/2021. Cabe destacar que, para fins de acompanhamento dos dados verificados e sua compatibilização com o histórico, não haverá alteração da Energia Armazenada Máxima (EARmáx). No entanto, para fins da programação da operação, serão considerados os níveis mínimos flexibilizados dos reservatórios, conforme declaração dos agentes. Dessa forma, o percentual do EAR verificado a partir de 14/09/2021 não serão comparáveis com os resultados obtidos pelos modelos DESSEM e DECOMP.

Desde o dia 01/01/2020, o despacho por ordem de mérito é indicado diariamente pelos resultados do modelo DESSEM. Assim, o despacho por ordem de mérito semanal, conforme publicado nesse documento, tem caráter apenas informativo. Da mesma forma, desde o dia 01/01/2021, a formação de preço deixou o formato semanal/patamar de carga e passou a ser horário, de acordo também com os resultados do modelo DESSEM.

O conteúdo desta publicação foi produzido pelo ONS com base em dados e informações de conhecimento público. É de responsabilidade exclusiva dos agentes e demais interessados a obtenção de outros dados e informações, a realização de análises, estudos e avaliações para fins de tomada de decisões, definição de estratégias de atuação, assunção de compromissos e obrigações e quaisquer outras finalidades, em qualquer tempo e sob qualquer condição. É proibida a reprodução ou utilização total ou parcial do presente sem a identificação da fonte.

2. NOTÍCIAS

Nos dias 23 e 24 de setembro será realizada a reunião de elaboração do PMO Outubro de 2021, com transmissão ao vivo através do site do ONS.

Como medida adicional de prevenção ao Coronavírus, o ONS informa que está suspensa, temporariamente, a participação presencial nas reuniões.

3. ANÁLISE DAS CONDIÇÕES HIDROMETEOROLÓGICAS

3.1. PREVISÃO PARA A PRÓXIMA SEMANA

A passagem de uma frente fria pela região Sul ocasiona chuva fraca nas bacias dos rios Jacuí, Uruguai e Iguaçu, e chuvisco em pontos isolados da bacia do rio Paranapanema e do trecho incremental a UHE Itaipu (Figura 1).

Figura 1 - Precipitação acumulada prevista pelo modelo ECMWF (ECMWF) para o período de 18/09/2021 a 24/09/2021.

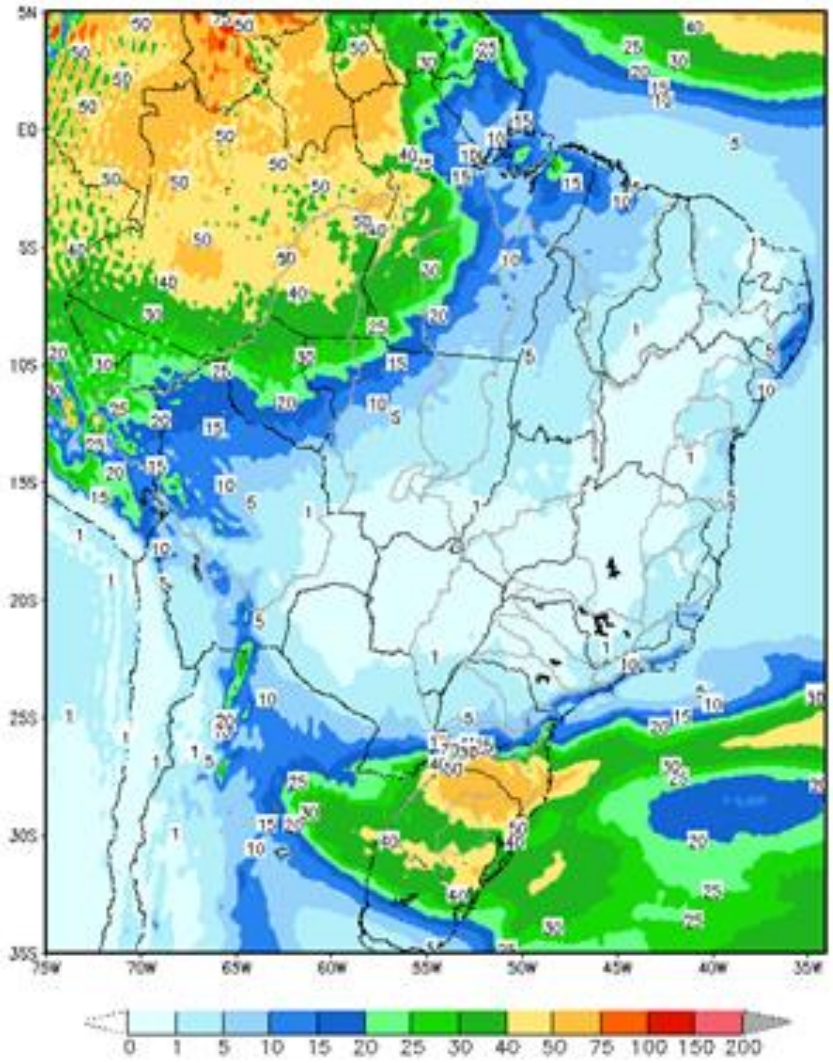

O conteúdo desta publicação foi produzido pelo ONS com base em dados e informações de conhecimento público. É de responsabilidade exclusiva dos agentes e demais interessados a obtenção de outros dados e informações, a realização de análises, estudos e avaliações para fins de tomada de decisões, definição de estratégias de atuação, assunção de compromissos e obrigações e quaisquer outras finalidades, em qualquer tempo e sob qualquer condição. É proibida a reprodução ou utilização total ou parcial do presente sem a identificação da fonte.

Em comparação com os valores estimados para a semana em curso, prevê-se para a próxima semana operativa ascensão nas afluências dos subsistemas Sudeste e Sul, estabilidade nas afluências do Nordeste e recessão nas afluências do subsistema Norte. A previsão mensal para setembro indica a ocorrência de afluências abaixo da média histórica para todos os subsistemas.

Tabela 1 – Previsão de ENAs da Revisão 3 de Setembro/2021

Revisão 3 do PMO de Setembro/2021 - ENAs previstas				
Subsistema	18/09 a 24/09/2021		Mês de setembro	
	MWmed	%MLT	MWmed	MWmed
SE/CO	11.670	59	11.467	58
S	16.642	142	8.564	73
NE	1.345	45	1.382	47
N	1.587	69	1.763	77

O conteúdo desta publicação foi produzido pelo ONS com base em dados e informações de conhecimento público. É de responsabilidade exclusiva dos agentes e demais interessados a obtenção de outros dados e informações, a realização de análises, estudos e avaliações para fins de tomada de decisões, definição de estratégias de atuação, assunção de compromissos e obrigações e quaisquer outras finalidades, em qualquer tempo e sob qualquer condição. É proibida a reprodução ou utilização total ou parcial do presente sem a identificação da fonte.

4. PREVISÃO DE CARGA

As projeções de carga para o mês de setembro/21 levaram em consideração a progressiva melhora dos setores de comércio e serviços do país, duramente afetados pela pandemia. O avanço da vacinação e a flexibilização das medidas restritivas explicam em grande parte esse resultado. Adicionalmente, a manutenção da produção Industrial em patamares elevados, também vem contribuindo para o desempenho da carga, apesar dos gargalos associados à escassez de insumos recentemente agravada por problemas de logísticas nos mercados internacionais e aumento da energia elétrica. Ressalta-se que durante as primeiras três semanas do mês ainda não se observam na carga, os efeitos relacionados ao programa de incentivo de redução voluntária do consumo.

Para a próxima semana operativa as sinalizações meteorológicas indicam para as capitais dos subsistemas Sudeste/Centro-Oeste e Sul, temperaturas em média, semelhantes às observadas na semana em curso, onde foram verificadas em grande parte dos dias, temperaturas elevadas nas capitais do subsistema Sudeste/Centro-Oeste, enquanto nas capitais dos subsistemas Sul foram observadas temperaturas mais amenas.

Nas capitais dos subsistemas Nordeste e Norte são esperadas para a próxima semana, temperaturas estáveis em relação à semana anterior, seguindo o comportamento típico para essa época do ano, porém destaca-se a expectativa de baixos totais de precipitação para a semana prevista.

Para o mês de setembro são previstos acréscimos de 0,1%, 7,4% e 6,2% para os subsistemas Sudeste/Centro-Oeste, Nordeste e Norte, respectivamente, e para o subsistema Sul há expectativa de decréscimo de 1,5%. As taxas apresentadas são resultantes da comparação com igual período do ano anterior.

Tabela 2 – Evolução da carga do PMO de Setembro 2021

Subsistema	CARGA SEMANAL (MWmed)					CARGA MENSAL (MWmed)	
	1ª Sem	2ª Sem	3ª Sem	4ª Sem	5ª Sem	set/21	Var. (%) set/21 -> set/20
SE/CO	38.885	39.640	41.513	41.558	41.625	40.846	0,1%
Sul	11.413	10.980	11.275	11.382	11.562	11.302	-1,5%
Nordeste	11.262	11.615	11.925	12.005	12.018	11.824	7,4%
Norte	6.295	6.319	6.414	6.403	6.412	6.377	6,2%
SIN	**67.855**	**68.554**	**71.127**	**71.348**	**71.617**	**70.349**	**1,5%**

O conteúdo desta publicação foi produzido pelo ONS com base em dados e informações de conhecimento público. É de responsabilidade exclusiva dos agentes e demais interessados a obtenção de outros dados e informações, a realização de análises, estudos e avaliações para fins de tomada de decisões, definição de estratégias de atuação, assunção de compromissos e obrigações e quaisquer outras finalidades, em qualquer tempo e sob qualquer condição. É proibida a reprodução ou utilização total ou parcial do presente sem a identificação da fonte.

5. PRINCIPAIS RESULTADOS

5.1. CUSTO MARGINAL DE OPERAÇÃO (CMO)

A tabela a seguir apresenta o CMO, por subsistema e patamar de carga para próxima semana operativa.

Tabela 3 – CMO por patamar de carga

Patamares de Carga	CMO (R$/MWh)			
	SE/CO	S	NE	N
Pesada	731,65	731,65	731,65	731,65
Média	718,88	718,88	717,08	718,88
Leve	698,14	698,14	698,14	698,14
Média Semanal	712,80	712,80	712,40	712,80

Na figura a seguir é apresentada a evolução do CMO médio semanal ao longo deste PMO.

Figura 2 – Evolução semanal do CMO

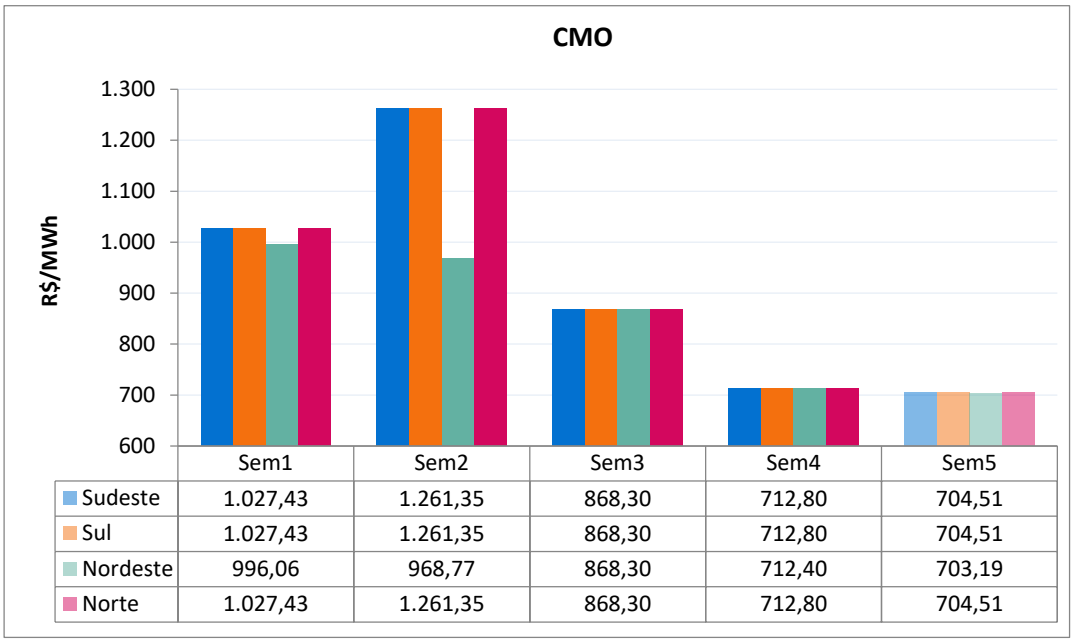

5.2. POLÍTICA DE OPERAÇÃO ENERGÉTICA

Para esta semana operativa, está prevista a seguinte política de intercâmbio de energia entre regiões:

Região SE/CO → Geração minimizada, onde possível, e dimensionada para fechamento do balanço energético do SIN.

Região Sul → Geração dimensionada para fechamento do balanço energético do SIN.

Região NE → Aumento da geração eólica e exportação de energia, modulando em função de seus recursos energéticos, respeitando-se os limites elétricos vigentes.

Região Norte → Redução da exploração das disponibilidades energéticas, respeitando-se os limites elétricos vigentes.

O conteúdo desta publicação foi produzido pelo ONS com base em dados e informações de conhecimento público. É de responsabilidade exclusiva dos agentes e demais interessados a obtenção de outros dados e informações, a realização de análises, estudos e avaliações para fins de tomada de decisões, definição de estratégias de atuação, assunção de compromissos e obrigações e quaisquer outras finalidades, em qualquer tempo e sob qualquer condição. É proibida a reprodução ou utilização total ou parcial do presente sem a identificação da fonte.

6. ANÁLISE DA VARIAÇÃO SEMANAL DO CMO

Esta análise visa identificar os principais parâmetros cujas atualizações impactaram os CMO deste PMO, em comparação com os valores obtidos na última revisão.

Foram realizados 8 estudos, onde o caso inicial foi construído com base nos dados oficiais da última revisão deste PMO. Neste primeiro estudo, denominado de "previsão perfeita", a partida dos reservatórios foi estimada conforme indicado para esta semana na última revisão.

O segundo estudo foi realizado com os dados do caso inicial sendo substituída a previsão de vazões.

A partir do conjunto de dados do segundo estudo foram elaborados os demais casos em que foram atualizadas, sequencialmente, as seguintes informações: níveis de partida dos reservatórios, previsão de carga, restrições hidráulicas, disponibilidade das usinas térmicas e hidráulicas, restrições de limites de intercâmbio e, por fim, os demais dados que compõem toda informação referente a atual revisão.

Os custos marginais de operação dos subsistemas Sudeste/Centro-Oeste, Sul e Norte estão acoplados e são apresentados na Figura 3. O principal fator que influenciou na redução do CMO destes subsistemas foi a atualização dos níveis de partida associada à atualização das restrições hidráulicas. A variação da disponibilidade das usinas térmicas e hidráulicas também foi um fator cuja atualização levou à redução do CMO. A atualização da previsão de vazões contribuiu no sentindo contrário, amortecendo de forma parcial a redução do CMO.

Figura 3 – Análise da variação do CMO nos subsistemas SE/CO, S e N

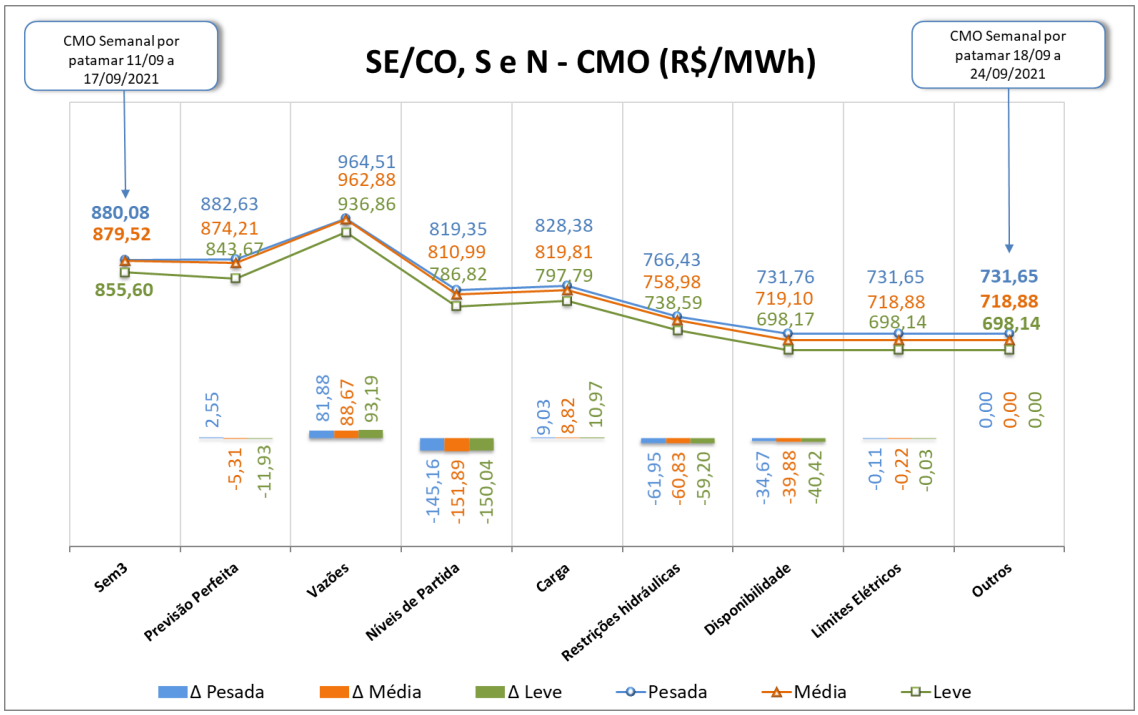

O conteúdo desta publicação foi produzido pelo ONS com base em dados e informações de conhecimento público. É de responsabilidade exclusiva dos agentes e demais interessados a obtenção de outros dados e informações, a realização de análises, estudos e avaliações para fins de tomada de decisões, definição de estratégias de atuação, assunção de compromissos e obrigações e quaisquer outras finalidades, em qualquer tempo e sob qualquer condição. É proibida a reprodução ou utilização total ou parcial do presente sem a identificação da fonte.

O subsistema Nordeste encontra-se desacoplado das demais regiões devido ao atingimento dos limites de transmissão de exportação de energia para os demais subsistemas. A figura a seguir apresenta a variação do CMO do subsistema Nordeste, onde observa-se análise semelhante à dos outros subsistemas.

Figura 4 – Análise da variação do CMO no subsistema Nordeste

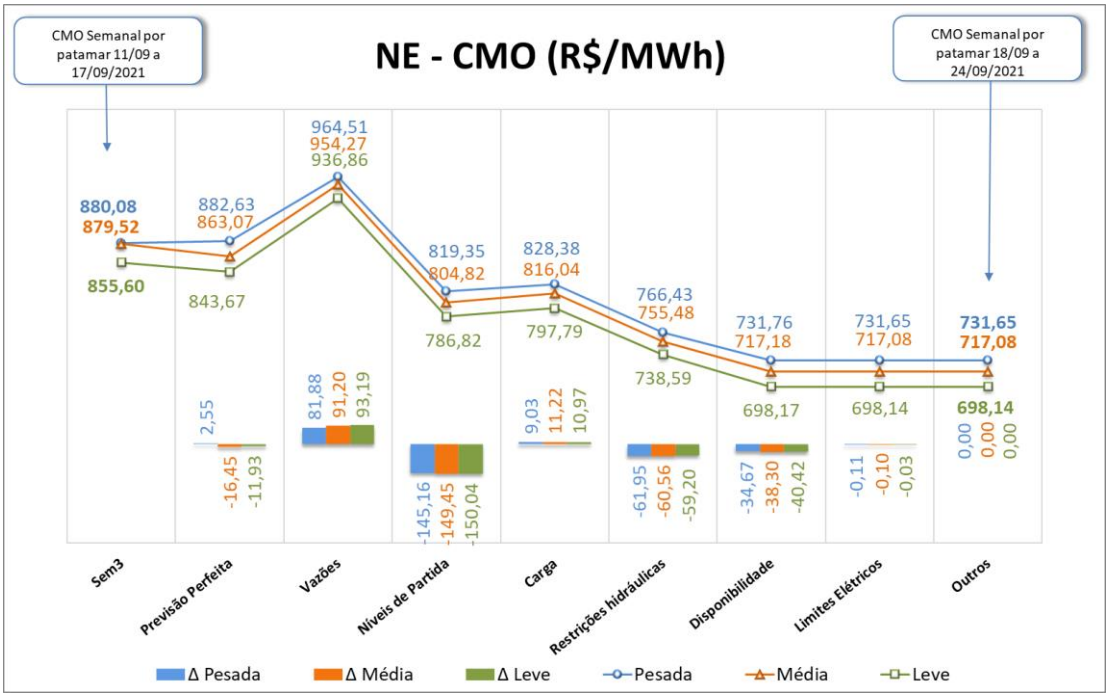

O conteúdo desta publicação foi produzido pelo ONS com base em dados e informações de conhecimento público. É de responsabilidade exclusiva dos agentes e demais interessados a obtenção de outros dados e informações, a realização de análises, estudos e avaliações para fins de tomada de decisões, definição de estratégias de atuação, assunção de compromissos e obrigações e quaisquer outras finalidades, em qualquer tempo e sob qualquer condição. É proibida a reprodução ou utilização total ou parcial do presente sem a identificação da fonte.

7. GERAÇÃO TÉRMICA

A Figura 5 apresenta, para cada subsistema, o despacho térmico por modalidade indicado pelo Decomp para a próxima semana operativa.

Figura 5 – Geração térmica para a próxima semana operativa

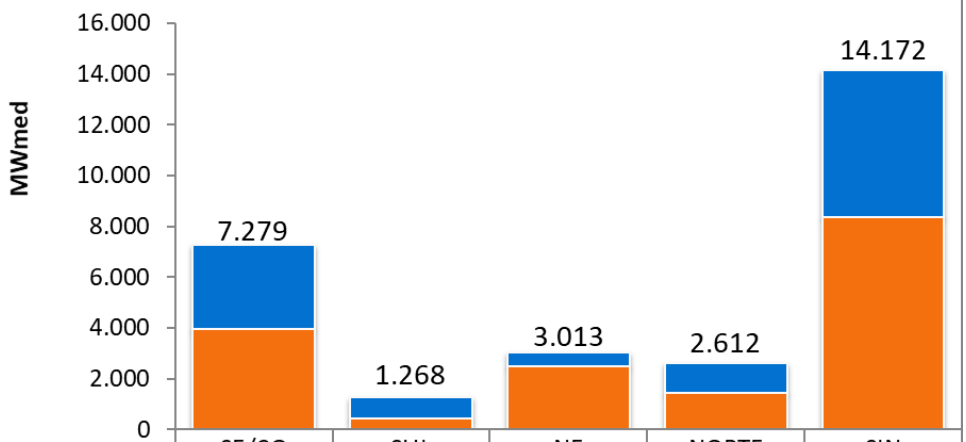

	SE/CO	SUL	NE	NORTE	SIN
RESTRIÇÃO ELÉTRICA	0	0	0	0	0
INFLEXIBILIDADE	3307	819	533	1165	5824
ORDEM DE MÉRITO	3972	449	2480	1447	8348

Na tabela abaixo segue a Indicação de despacho antecipado por ordem de mérito de custo para a semana de 20/11/2021 a 26/11/2021.

Tabela 4 – UTEs com contrato de combustível GNL

UTE			Benefício (R$/MWh)		
Nome	Cod	CVU (R$/MWh)	Carga Pesada	Carga Média	Carga Leve
SANTA CRUZ	86	284,35	575,63 (1)	575,63 (1)	575,63 (1)
LUIZORMELO	15	438,83	575,63 (1)	575,63 (1)	575,63 (1)
PSERGIPE I	224	310,18	562,88 (1)	562,75 (1)	562,72 (1)

(1) Comandado o despacho antecipado por ordem de mérito de custo nesse patamar

(2) NÃO foi comandado o despacho antecipado por ordem de mérito de custo nesse patamar

Assim sendo, há previsão de despacho antecipado por ordem de mérito de custo para as UTE Santa Cruz, Luiz O. R. Melo e Porto Sergipe I, para a semana de 20/11 a 26/11/2021.

O conteúdo desta publicação foi produzido pelo ONS com base em dados e informações de conhecimento público. É de responsabilidade exclusiva dos agentes e demais interessados a obtenção de outros dados e informações, a realização de análises, estudos e avaliações para fins de tomada de decisões, definição de estratégias de atuação, assunção de compromissos e obrigações e quaisquer outras finalidades, em qualquer tempo e sob qualquer condição. É proibida a reprodução ou utilização total ou parcial do presente sem a identificação da fonte.

8. IMPORTAÇÃO DE ENERGIA DA REPÚBLICA ORIENTAL DO URUGUAI

8.1. República Oriental do Uruguai

Para a próxima semana operativa, foram declaradas as seguintes ofertas de importação de energia da República Oriental do Uruguai para o Sistema Interligado Nacional - SIN através das conversoras de Rivera (70 MW) e Melo (500 MW).

- **Eletrobras**

Tabela 5 – Energia ofertada para importação

	Oferta de Energia para a Semana de 18/09 a 24/09 (MWmed)				
	Bloco 1	Bloco 2	Bloco 3	Bloco 4	Total
Carga Pesada	100	50	85	50	285
Carga Média	100	50	85	50	285
Carga Leve	100	50	85	50	285
CVU (R$/MWh)	824,30	1.364,64	1.732,89	1.923,23	

- **Enel**

Conforme declaração do agente, esta importação poderá ser realizada exclusivamente pela conversora Melo.

Tabela 6 – Energia ofertada para importação

	Oferta de Energia para a Semana de 18/09 a 24/09 (MWmed)				
	Bloco 1	Bloco 2	Bloco 3	Bloco 4	Total
Carga Pesada	100	50	85	50	285
Carga Média	100	50	85	50	285
Carga Leve	100	50	85	50	285
CVU (R$/MWh)	830,00	1.370,99	1.734,46	1.925,76	

8.2. República da Argentina

- **Enel**

Para a próxima semana operativa, foi declarada a seguinte oferta de importação de energia da República da Argentina para o SIN através das conversoras de Garabi 1 (1.100 MW) e Garabi 2 (1.100 MW).

Tabela 7 – Energia ofertada para importação

	Oferta de Energia para a Semana de 18/09 a 24/09 (MWmed)				
	Bloco 1	Bloco 2	Bloco 3	Bloco 4	Total
Carga Pesada	200	200	600	1.200	2.200
Carga Média	200	200	600	1.200	2.200
Carga Leve	200	200	600	1.200	2.200
CVU (R$/MWh)	1.389,88	1.518,04	1.836,09	1.961,15	

Nota: Detalhes sobre a importação de energia vide Portaria Nº 339, de 15 de agosto de 2018 disponível em: http://pesquisa.in.gov.br/imprensa/jsp/visualiza/index.jsp?data=17/08/2018&jornal=515&pagina=60&totalArquivos=136

O conteúdo desta publicação foi produzido pelo ONS com base em dados e informações de conhecimento público. É de responsabilidade exclusiva dos agentes e demais interessados a obtenção de outros dados e informações, a realização de análises, estudos e avaliações para fins de tomada de decisões, definição de estratégias de atuação, assunção de compromissos e obrigações e quaisquer outras finalidades, em qualquer tempo e sob qualquer condição. É proibida a reprodução ou utilização total ou parcial do presente sem a identificação da fonte.

9. ARMAZENAMENTOS OPERATIVOS

Para uma melhor avaliação de diversos cenários hidrometeorológicos, notadamente, aqueles de curto prazo e suas influências nas previsões de vazões nos subsistemas, os resultados desta revisão do PMO contemplam cenários de afluências visando melhor representar a ocorrência de precipitação e, consequentemente, seus efeitos sobre as afluências e armazenamentos.

Além dos resultados associados ao valor esperado das previsões de afluências, as simulações operativas também foram realizadas com os limites superior e inferior das previsões de afluências. Apresentamos a seguir os resultados obtidos com a aplicação dos diferentes cenários de afluência.

Tabela 8 – Previsão de ENA dos cenários de sensibilidade

Subsistema	ENERGIAS NATURAIS AFLUENTES					
	Previsão Mensal					
	LI		VE		LS	
	(MWmed)	%MLT	(MWmed)	%MLT	(MWmed)	%MLT
SE/CO	10.449	**53**	11.467	**58**	12.565	**64**
Sul	5.315	**45**	8.564	**73**	11.744	**100**
Nordeste	1.291	**44**	1.382	**47**	1.471	**50**
Norte	1.666	**73**	1.763	**77**	1.869	**82**

Tabela 9 – Previsão de %EARmáx para o final do mês

Subsistema	% EARmáx 17/09	% EARmáx - 30/09		
	NÍVEL INICIAL	NÍVEL PMO		
	VE	LI	VE	LS
SE/CO	19,4	16,7	17,1	17,4
Sul	27,5	20,2	29,3	37,6
Nordeste	44,0	40,1	40,3	40,6
Norte	64,7	61,5	62,0	62,1

O conteúdo desta publicação foi produzido pelo ONS com base em dados e informações de conhecimento público. É de responsabilidade exclusiva dos agentes e demais interessados a obtenção de outros dados e informações, a realização de análises, estudos e avaliações para fins de tomada de decisões, definição de estratégias de atuação, assunção de compromissos e obrigações e quaisquer outras finalidades, em qualquer tempo e sob qualquer condição. É proibida a reprodução ou utilização total ou parcial do presente sem a identificação da fonte.

10. RESERVATÓRIOS EQUIVALENTES DE ENERGIA

A seguir são apresentadas as previsões de Energia Natural Afluente para a próxima semana operativa e para o mês de setembro, bem como as previsões de Energia Armazenada nos Reservatórios Equivalentes de Energia – REE, desta revisão do PMO.

Tabela 10 – Previsão de ENA por REE

Valor Esperado das Energias Naturais Afluentes				
REE	Previsão Semanal		Previsão Mensal	
	18/09/2021 a 24/09/2021		set/21	
	(MWmed)	%MLT	(MWmed)	%MLT
Sudeste	1.230	51	1.323	54
Madeira	2.298	128	1.799	100
Teles Pires	579	85	551	81
Itaipu	1.804	68	1.871	70
Paraná	4.759	47	4.963	49
Paranapanema	1.023	50	965	47
Sul	13.475	194	6.695	97
Iguaçu	3.168	66	1.869	39
Nordeste	1.345	45	1.382	47
Norte	829	56	926	63
Belo Monte	122	32	174	46
Manaus	647	150	695	161

Tabela 11 – Previsão de %EARmáx por REE

% Energia Armazenável Máxima		
REE	Previsão Semanal	Previsão Mensal
	24/set	30/set
	(%EARmáx)	(%EARmáx)
Sudeste	25,6	24,3
Madeira	32,4	26,6
Teles Pires	46,1	35,4
Itaipu	3,2	0,5
Paraná	14,6	13,6
Paranapanema	28,8	28,6
Sul	53,3	50,7
Iguaçu	13,8	10,0
Nordeste	42,1	40,3
Norte	62,5	61,2
Belo Monte	93,7	91,8
Manaus	75,9	75,0

O conteúdo desta publicação foi produzido pelo ONS com base em dados e informações de conhecimento público. É de responsabilidade exclusiva dos agentes e demais interessados a obtenção de outros dados e informações, a realização de análises, estudos e avaliações para fins de tomada de decisões, definição de estratégias de atuação, assunção de compromissos e obrigações e quaisquer outras finalidades, em qualquer tempo e sob qualquer condição. É proibida a reprodução ou utilização total ou parcial do presente sem a identificação da fonte.

11. DESPACHO TÉRMICO POR MODALIDADE, PATAMAR DE CARGA E USINA

Nas tabelas abaixo, a diferenciação entre geração por inflexibilidade e por ordem de mérito tem caráter informativo, com o objetivo de detalhar a informação de inflexibilidade enviada pelos respectivos agentes para esta revisão do PMO. Ressalta-se que nas etapas de Programação Diária e Tempo Real, o montante despachado nas usinas termelétricas indicadas por ordem de mérito é plenamente intitulado como ordem de mérito.

REGIÃO SUDESTE/CENTRO-OESTE																	
Térmicas Potência (MW)	Combustível	CVU (R$/MWh)	Inflexibilidade			Ordem de Mérito			Total Mérito e INFL.			Razão Elétrica			Total UTE		
			P	M	L	P	M	L	P	M	L	P	M	L	P	M	L
ATLAN_CSA (255)	Resíduos	0,00	171,0	171,0	171,0				171,0	171,0	171,0				171,0	171,0	171,0
ANGRA 2 (1350)	Nuclear	20,12	1350,0	1350,0	1350,0	0,0	0,0	0,0	1350,0	1350,0	1350,0				1350,0	1350,0	1350,0
ANGRA 1 (640)	Nuclear	31,17	640,0	640,0	640,0	0,0	0,0	0,0	640,0	640,0	640,0				640,0	640,0	640,0
NORTEFLU 1 (400)	Gás	80,69	400,0	400,0	400,0	0,0	0,0	0,0	400,0	400,0	400,0				400,0	400,0	400,0
NORTEFLU 2 (100)	Gás	92,91	100,0	100,0	100,0	0,0	0,0	0,0	100,0	100,0	100,0				100,0	100,0	100,0
O.PINTADA (50)	Biomassa	112,47	7,0	7,0	7,0	43,0	43,0	43,0	50,0	50,0	50,0				50,0	50,0	50,0
UTE STA VI (41)	Biomassa	121,49	13,0	13,0	13,0	28,4	28,4	28,4	41,4	41,4	41,4				41,4	41,4	41,4
PREDILECTA (5)	Biomassa	158,95	1,0	1,0	1,0	4,0	4,0	4,0	5,0	5,0	5,0				5,0	5,0	5,0
NORTEFLU 3 (200)	Gás	176,88	200,0	200,0	200,0	0,0	0,0	0,0	200,0	200,0	200,0				200,0	200,0	200,0
ATLANTICO (235)	Resíduos	206,08	218,7	218,7	218,7	0,0	0,0	0,0	218,7	218,7	218,7				218,7	218,7	218,7
T.LAGOAS (350)	Gás	263,19				270,0	270,0	270,0	270,0	270,0	270,0				270,0	270,0	270,0
BAIXADA FL (530)	Gás	280,55				530,0	530,0	530,0	530,0	530,0	530,0				530,0	530,0	530,0
JUIZ DE FO (87)	Gás	283,74				75,0	75,0	75,0	75,0	75,0	75,0				75,0	75,0	75,0
SANTA CRUZ (500)	GNL	284,35				0,0	0,0	0,0	0,0	0,0	0,0				0,0	0,0	0,0
ST.CRUZ 34 (436)	Óleo	310,41															
TERMORIO (1036)	Gás	330,93	100,0	100,0	100,0	510,0	510,0	510,0	610,0	610,0	610,0				610,0	610,0	610,0
CUBATAO (216)	Gás	357,66	106,7	106,7	106,7	0,0	0,0	0,0	106,7	106,7	106,7				106,7	106,7	106,7
SEROPEDICA (386)	Gás	411,59				353,5	353,5	353,5	353,5	353,5	353,5				353,5	353,5	353,5
LUIZORMELO (204)	GNL	438,83				204,0	204,0	204,0	204,0	204,0	204,0				204,0	204,0	204,0
PIRAT.12 O (200)	Gás	470,34															
NPIRATINGA (572)	Gás	548,04				490,0	490,0	490,0	490,0	490,0	490,0				490,0	490,0	490,0
UTE GNA I (1338)	Gás	552,56				1338,0	1338,0	1338,0	1338,0	1338,0	1338,0				1338,0	1338,0	1338,0
NORTEFLU 4 (127)	Gás	631,70				126,0	126,0	126,0	126,0	126,0	126,0				126,0	126,0	126,0
T.MACAE (929)	Gás	739,82															
TNORTE 2 (340)	Óleo	910,86															
IBIRITE (226)	Gás	959,34															
VIANA (175)	Óleo	962,90															
CAMPOS (25)	Gás	978,10															
DAIA (44)	Diesel	1020,95															
GOIANIA 2 (140)	Diesel	1067,44															
CUIABA CC (529)	Gás	1393,69															
XAVANTES (54)	Diesel	1467,03															
PALMEIR_GO (176)	Diesel	1475,51															
W.ARJONA O	Diesel	2042,39															
W.ARJONA (177)	Gás	2443,68															
TOTAL SE/CO (12073)			3307,4	3307,4	3307,4	3971,9	3971,9	3971,9	7279,3	7279,3	7279,3	0,0	0,0	0,0	7279,3	7279,3	7427,3

REGIÃO SUL																	
Térmicas Potência (MW)	Combustível	CVU (R$/MWh)	Inflexibilidade			Ordem de Mérito			Total Mérito e INFL.			Razão Elétrica			Total UTE		
			P	M	L	P	M	L	P	M	L	P	M	L	P	M	L
PAMPA SUL (345)	Carvão	69,75				0,0	0,0	0,0	0,0	0,0	0,0				0,0	0,0	0,0
SAO SEPE (8)	Biomassa	87,75	7,0	7,0	7,0	0,0	0,0	0,0	7,0	7,0	7,0				7,0	7,0	7,0
CANDIOTA_3 (350)	Carvão	92,68	310,0	310,0	310,0	0,0	0,0	0,0	310,0	310,0	310,0				310,0	310,0	310,0
J.LACER. C (363)	Carvão	229,27	200,0	200,0	200,0	130,0	130,0	130,0	330,0	330,0	330,0				330,0	330,0	330,0
J.LACER. B (262)	Carvão	271,21	160,0	160,0	160,0	60,0	60,0	60,0	220,0	220,0	220,0				220,0	220,0	220,0
J.LAC. A2 (132)	Carvão	278,38	70,0	70,0	70,0	40,0	40,0	40,0	110,0	110,0	110,0				110,0	110,0	110,0
J.LAC. A1 (100)	Carvão	304,61	70,0	70,0	70,0	10,0	10,0	10,0	80,0	80,0	80,0				80,0	80,0	80,0
MADEIRA (4)	Biomassa	332,22	2,0	2,0	2,0	1,0	1,0	1,0	3,0	3,0	3,0				3,0	3,0	3,0
FIGUEIRA (20)	Carvão	475,68				0,0	0,0	0,0	0,0	0,0	0,0				0,0	0,0	0,0
CANOAS (249)	Diesel	698,14				230,0	230,0	183,2	230,0	230,0	183,2				230,0	230,0	183,2
ARAUCARIA (484)	Gás	1276,44															
URUGUAIANA (640)	Gás	1589,58															
TOTAL SUL (2957)			819,0	819,0	819,0	471,0	471,0	424,2	1290,0	1290,0	1243,2	0,0	0,0	0,0	1290,0	1290,0	1243,2

O conteúdo desta publicação foi produzido pelo ONS com base em dados e informações de conhecimento público. É de responsabilidade exclusiva dos agentes e demais interessados a obtenção de outros dados e informações, a realização de análises, estudos e avaliações para fins de tomada de decisões, definição de estratégias de atuação, assunção de compromissos e obrigações e quaisquer outras finalidades, em qualquer tempo e sob qualquer condição. É proibida a reprodução ou utilização total ou parcial do presente sem a identificação da fonte.

REGIÃO NORDESTE

Térmicas Potência (MW)	Combustível	CVU (R$/MWh)	Inflexibilidade			Ordem de Mérito			Total Mérito e INFL.			Razão Elétrica			Total UTE		
			P	M	L	P	M	L	P	M	L	P	M	L	P	M	L
ALTOS (13)	Diesel	0,00															
ARACATI (11)	Diesel	0,00															
BATURITE (11)	Diesel	0,00															
C.MAIOR (13)	Diesel	0,00															
CAUCAIA (15)	Diesel	0,00															
CRATO (13)	Diesel	0,00															
IGUATU (15)	Diesel	0,00															
JUAZEIRO N (15)	Diesel	0,00															
MARAMBAIA (13)	Diesel	0,00															
NAZARIA (13)	Diesel	0,00															
PECEM (15)	Diesel	0,00															
ERB CANDEI (17)	Biomassa	87,81				0,0	0,0	0,0	0,0	0,0	0,0				0,0	0,0	0,0
PROSPERIDA (28)	Gás	165,61				28,0	28,0	28,0	28,0	28,0	28,0				28,0	28,0	28,0
TERMOPE (533)	Gás	178,30	532,7	532,7	532,7	0,0	0,0	0,0	532,7	532,7	532,7				532,7	532,7	532,7
FORTALEZA (327)	Gás	245,46				326,6	326,6	326,6	326,6	326,6	326,6				326,6	326,6	326,6
PSERGIPE I (1516)	GNL	310,18				1040,0	1040,0	1040,0	1040,0	1040,0	1040,0				1040,0	1040,0	1040,0
P.PECEM2 (365)	Carvão	443,79				365,0	365,0	365,0	365,0	365,0	365,0				365,0	365,0	365,0
P.PECEM1 (720)	Carvão	447,60				720,0	720,0	720,0	720,0	720,0	720,0				720,0	720,0	720,0
SYKUE I (30)	Biomassa	510,12				0,0	0,0	0,0	0,0	0,0	0,0				0,0	0,0	0,0
BAHIA_1 (31)	Óleo	819,79															
PERNAMBU_3 (201)	Óleo	831,02															
MARACANAU (168)	Óleo	937,10															
TERMOCABO (50)	Óleo	951,07															
TERMONE (171)	Óleo	954,27															
TERMOPB (171)	Óleo	954,27															
CAMPINA_GR (169)	Óleo	962,92															
SUAPE II (381)	Óleo	985,73															
POTIGUAR_3 (66)	Diesel	1004,31															
POTIGUAR (53)	Diesel	1004,32															
VALE ACU (368)	Gás	1009,19															
AREMBEPE (150)	Óleo	1023,71															
MURICY (147)	Óleo	1023,71															
T.BAHIA (186)	Gás	1042,36															
GLOBAL I (149)	Óleo	1090,85															
GLOBAL II (149)	Óleo	1090,85															
PETROLINA (136)	Óleo	1123,16															
PAU FERRO (94)	Diesel	1136,93															
TERMOMANAU (143)	Diesel	1136,93															
TERMOCEARA (223)	Diesel	1582,71															
TOTAL NE (6889)			532,7	532,7	532,7	1439,6	1439,6	1439,6	1972,3	1972,3	1972,3	####	####	####	3012,3	3012,3	3012,3

REGIÃO NORTE

Térmicas Potência (MW)	Combustível	CVU (R$/MWh)	Inflexibilidade			Ordem de Mérito			Total Mérito e INFL.			Razão Elétrica			Total UTE		
			P	M	L	P	M	L	P	M	L	P	M	L	P	M	L
C. ROCHA (85)	Gás	0,00	65,0	65,0	65,0				65,0	65,0	65,0				65,0	65,0	65,0
JARAQUI (75)	Gás	0,00	63,0	63,0	63,0				63,0	63,0	63,0				63,0	63,0	63,0
MANAUARA (67)	Gás	0,00	64,5	64,5	64,3				64,5	64,5	64,3				64,5	64,5	64,3
PONTA NEGR (66)	Gás	0,00	64,0	64,0	64,0				64,0	64,0	64,0				64,0	64,0	64,0
TAMBAQUI (93)	Gás	0,00	63,0	63,0	63,0				63,0	63,0	63,0				63,0	63,0	63,0
MARANHAO3 (519)	Gás	85,72	490,0	515,8	513,0	0,0	0,0	0,0	490,0	515,8	513,0				490,0	515,8	513,0
APARECIDA (166)	Gás	128,41	75,0	75,0	75,0	71,0	71,0	68,4	146,0	146,0	143,4				146,0	146,0	143,4
UTE MAUA 3 (591)	Gás	128,41	264,0	264,0	264,0	200,0	142,1	62,5	464,0	406,1	326,5				464,0	406,1	326,5
PARNAIB_IV (56)	Gás	151,69				56,3	56,3	56,3	56,3	56,3	56,3				56,3	56,3	56,3
N.VEN2_L22 (27)	Gás	232,27				27,0	27,0	27,0	27,0	27,0	27,0				27,0	27,0	27,0
N.VEN2_L7 (151)	Gás	232,27				143,0	150,3	149,6	143,0	150,3	149,6				143,0	150,3	149,6
MARAN_VL_7 (336)	Gás	260,71				323,9	335,1	333,9	323,9	335,1	333,9				323,9	335,1	333,9
MARANIVL_7 (336)	Gás	260,71				323,8	335,1	333,9	323,8	335,1	333,9				323,8	335,1	333,9
MARAN_VL22 (1)	Gás	260,72				1,1	1,1	1,1	1,1	1,1	1,1				1,1	1,1	1,1
MARANIVL22 (1)	Gás	260,72				1,1	1,1	1,1	1,1	1,1	1,1				1,1	1,1	1,1
P. ITAQUI (360)	Carvão	436,76				360,1	360,1	360,1	360,1	360,1	360,1				360,1	360,1	360,1
GERAMAR1 (166)	Óleo	962,88															
GERAMAR2 (166)	Óleo	962,88															
TOTAL NORTE (3264)			1148,5	1174,3	1171,3	1507,3	1479,2	1393,9	2655,8	2653,5	2565,2	0,0	0,0	0,0	2655,8	2653,5	2565,2

O conteúdo desta publicação foi produzido pelo ONS com base em dados e informações de conhecimento público. É de responsabilidade exclusiva dos agentes e demais interessados a obtenção de outros dados e informações, a realização de análises, estudos e avaliações para fins de tomada de decisões, definição de estratégias de atuação, assunção de compromissos e obrigações e quaisquer outras finalidades, em qualquer tempo e sob qualquer condição. É proibida a reprodução ou utilização total ou parcial do presente sem a identificação da fonte.