1. APRESENTAÇÃO

No mês de setembro os maiores totais de precipitação ficaram restritos às regiões Sul e Norte do país, atingindo as bacias dos rios Jacuí, Uruguai, Iguaçu e no trecho baixo do Xingu, onde foram observados totais próximos a média histórica para o mês. Nas demais bacias hidrográficas de interesse do SIN o total acumulado do mês ficou abaixo da média histórica.

Na semana de 25/09/2021 a 01/10/2021 deve ocorrer precipitação nas bacias dos rios Jacuí, Uruguai, Iguaçu, e em pontos isolados das bacias dos rios Paranapanema, Tietê, Grande, Paranaíba, Tocantins, do trecho incremental a UHE Itaipu e da calha principal do rio Paraná.

Para a semana operativa de 25/09 a 01/10/2021, houve oferta de energia da República Oriental do Uruguai e da República da Argentina. De acordo com o Art. 2º da Portaria MME nº 339, de 15 de agosto de 2018, as ofertas para importação de energia não foram consideradas na elaboração do PMO.

Os valores médios semanais do Custo Marginal de Operação – CMO dos subsistemas do SIN sofreram as seguintes alterações em relação à semana anterior:

- SE/CO: de R$ 712,80/MWh para R$ 533,36/MWh
- Sul: de R$ 712,80/MWh para R$ 533,36/MWh
- Nordeste: de R$ 712,40/MWh para R$ 533,36/MWh
- Norte: de R$ 712,80/MWh para R$ 533,36/MWh

A Câmara de Regras Excepcionais para Gestão Hidroenergética (CREG), em sua 5ª Reunião (Extraordinária) realizada em 31/08/2021, determinou ao ONS, concessionários e autorizados de geração de energia elétrica, de forma imediata e com vigência até o final de novembro de 2021, que operem os correspondentes reservatórios até o limite físico de exploração energética, mediante flexibilização de regras operativas que estabeleçam níveis mínimos de armazenamento, resguardados os usos prioritários de que trata o inciso III do art. 1º da Lei nº 9.433/1997.

A partir do dia 14/09/2021, o reservatório da UHE Ilha Solteira passou a operar com cotas inferiores à sua cota mínima operativa oficial, assim como o reservatório da UHE Três Irmãos, em 15/09/2021. Cabe destacar que, para fins de acompanhamento dos dados verificados e sua compatibilização com o histórico, não haverá alteração da Energia Armazenada Máxima (EARmáx). No entanto, para fins da programação da operação, serão considerados os níveis mínimos flexibilizados dos reservatórios, conforme declaração dos agentes. Dessa forma, o percentual do EAR verificado a partir de 14/09/2021 não serão comparáveis com os resultados obtidos pelos modelos DESSEM e DECOMP.

Desde o dia 01/01/2020, o despacho por ordem de mérito é indicado diariamente pelos resultados do modelo DESSEM. Assim, o despacho por ordem de mérito semanal, conforme publicado nesse documento, tem caráter apenas informativo. Da mesma forma, desde o dia 01/01/2021, a formação de preço deixou o formato semanal/patamar de carga e passou a ser horário, de acordo também com os resultados do modelo DESSEM.

O conteúdo desta publicação foi produzido pelo ONS com base em dados e informações de conhecimento público. É de responsabilidade exclusiva dos agentes e demais interessados a obtenção de outros dados e informações, a realização de análises, estudos e avaliações para fins de tomada de decisões, definição de estratégias de atuação, assunção de compromissos e obrigações e quaisquer outras finalidades, em qualquer tempo e sob qualquer condição. É proibida a reprodução ou utilização total ou parcial do presente sem a identificação da fonte.

2. NOTÍCIAS

Nos dias 28 e 29 de outubro será realizada a reunião de elaboração do PMO Novembro de 2021, com transmissão ao vivo através do site do ONS.

Como medida adicional de prevenção ao Coronavírus, o ONS informa que está suspensa, temporariamente, a participação presencial nas reuniões.

3. INFORMAÇÕES PARA ESTUDOS ENERGÉTICOS DE MÉDIO PRAZO - CONSTRUÇÃO DA FUNÇÃO DE CUSTO FUTURO

A atualização de dados para os estudos energéticos de médio prazo é realizada mensalmente quando da elaboração do PMO, tendo por base as informações fornecidas pela ANEEL, MME, EPE, CCEE e Agentes, além de diversas áreas do ONS.

3.1. ATUALIZAÇÃO DAS INFORMAÇÕES ESTRUTURAIS

3.1.1. Oferta

Nas **Figura 1**, **Figura 2** e **Figura 3**, a seguir, são apresentadas as evoluções da oferta hidroelétrica, termoelétrica e da disponibilidade das usinas não simuladas individualmente, respectivamente, em comparação ao PMO de setembro/2021, identificando eventuais atrasos ou antecipações de cronograma feitos na reunião de acompanhamento do Departamento de Monitoramento do Setor Elétrico – DMSE/MME, realizada em 16/09/2021.

Figura 1 - Evolução da potência instalada das UHEs

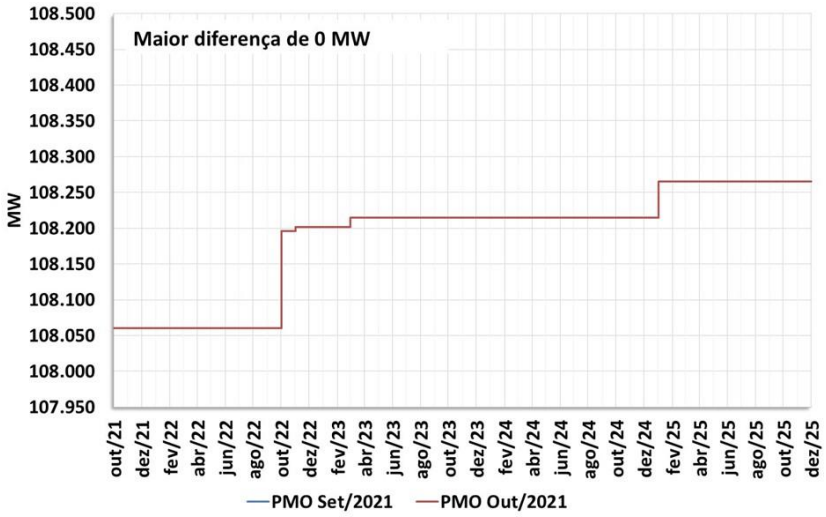

O conteúdo desta publicação foi produzido pelo ONS com base em dados e informações de conhecimento público. É de responsabilidade exclusiva dos agentes e demais interessados a obtenção de outros dados e informações, a realização de análises, estudos e avaliações para fins de tomada de decisões, definição de estratégias de atuação, assunção de compromissos e obrigações e quaisquer outras finalidades, em qualquer tempo e sob qualquer condição. É proibida a reprodução ou utilização total ou parcial do presente sem a identificação da fonte.

Figura 2 - Evolução da potência instalada das UTEs

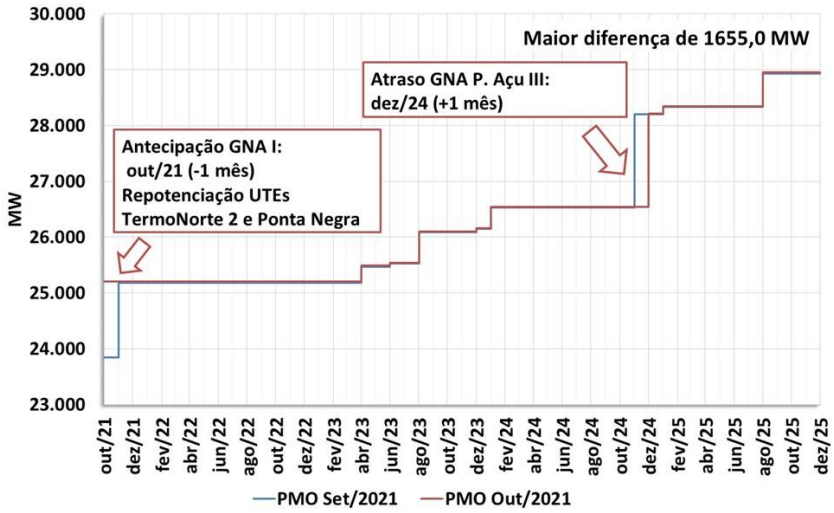

Figura 3 - Evolução da disponibilidade das usinas não simuladas

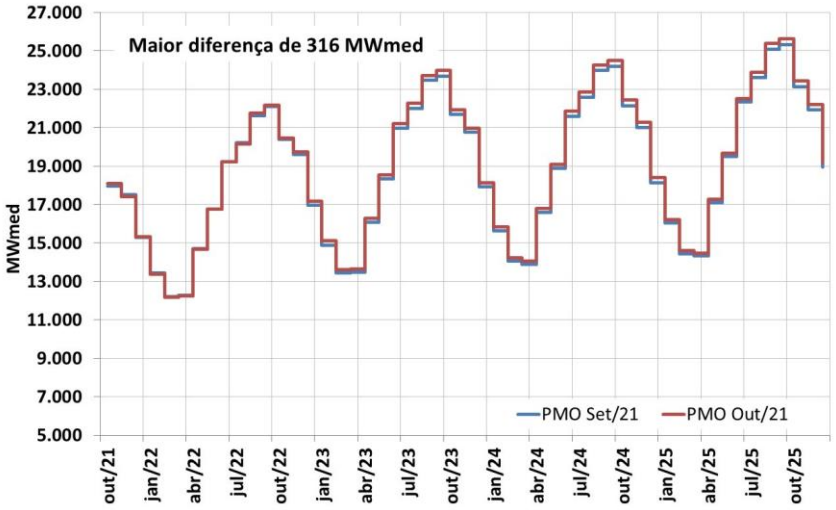

3.1.2. Armazenamentos Iniciais

Na **Figura 4**, a seguir, são apresentados os armazenamentos iniciais equivalentes por subsistema, considerados nos modelos de otimização para a elaboração do PMO de outubro/2021, comparados com os do PMO de Setembro/2021.

O conteúdo desta publicação foi produzido pelo ONS com base em dados e informações de conhecimento público. É de responsabilidade exclusiva dos agentes e demais interessados a obtenção de outros dados e informações, a realização de análises, estudos e avaliações para fins de tomada de decisões, definição de estratégias de atuação, assunção de compromissos e obrigações e quaisquer outras finalidades, em qualquer tempo e sob qualquer condição. É proibida a reprodução ou utilização total ou parcial do presente sem a identificação da fonte.

Figura 4 - Energia armazenada inicial em outubro/21 e setembro/21 – [% EARmáx]

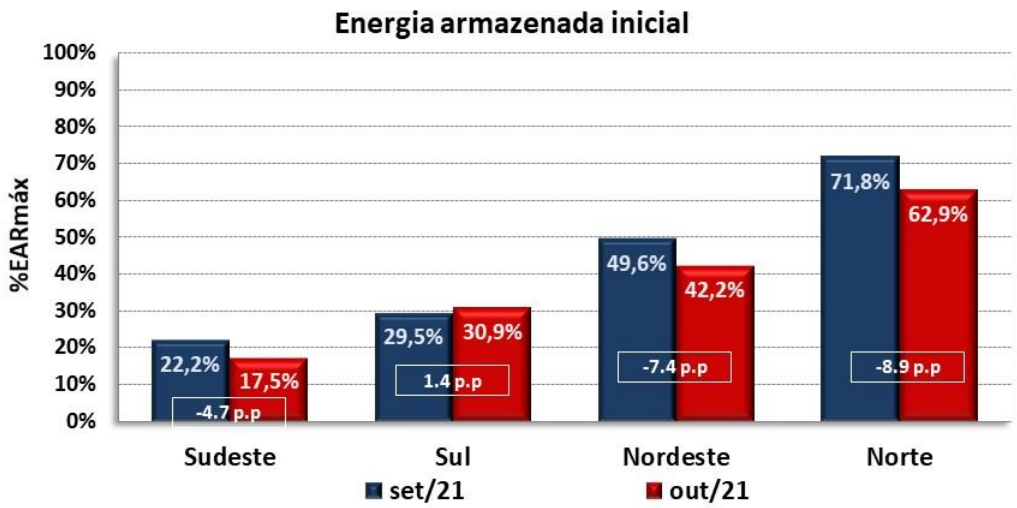

3.1.3. Tendência Hidrológica

Na Tabela 1, a seguir, são apresentadas as tendências hidrológicas consideradas pelo modelo NEWAVE para o PMO de Outubro/2021, comparadas com o PMO de Setembro/2021.

Tabela 1 – Tendência hidrológica para o PMO de outubro/2021 – NEWAVE [%MLT]

	PMO Setembro/2021				PMO Outubro/2021			
MÊS	SE/CO	S	NE	N	SE/CO	S	NE	N
abr/21	63	35	35	87	63	35	35	88
mai/21	63	29	37	86	63	29	37	87
jun/21	66	58	38	72	66	58	38	72
Jul/21	61	43	42	81	61	43	42	81
ago/21	59	34	43	79	59	33	43	80
set/21					55	68	46	78

* ≥100% MLT < 100% MLT

O conteúdo desta publicação foi produzido pelo ONS com base em dados e informações de conhecimento público. É de responsabilidade exclusiva dos agentes e demais interessados a obtenção de outros dados e informações, a realização de análises, estudos e avaliações para fins de tomada de decisões, definição de estratégias de atuação, assunção de compromissos e obrigações e quaisquer outras finalidades, em qualquer tempo e sob qualquer condição. É proibida a reprodução ou utilização total ou parcial do presente sem a identificação da fonte.

3.2. DEMAIS ATUALIZAÇÕES

Adicionalmente, neste PMO ocorreram os seguintes destaques:

- Horizonte de estudo: outubro de 2021 a dezembro de 2025;
- Cronograma de Obras – Reunião DMSE-G de 16/09/2021 com destaque para inclusão no ACL da UTE T. Norte I (64 MW) com previsão de operação em nov/2021, entretanto essa usina permanece com disponibilidade nula até que tenha contrato de combustível e CVU válido;
- CVUs de UTEs vendedoras em leilão;
- Entrada em operação comercial por tempo determinado da UG 3 da UTE W. Arjona (até set/21), conforme Despacho SFG/ANEEL nº 2.629/2021;
- Entrada em operação comercial das UG 1 a 4 da UTE GNA I a partir de 16/09/2021, conforme Despacho SFG/ANEEL nº 2.865/2021;
- Suspensão da operação comercial da UTE Figueira, conforme Despacho SFG/ANEEL nº 2.645/2021 e consideração do CVU pré-modernização para todo o horizonte;
- Compatibilização da disponibilidade térmica para os dois primeiros meses de acordo com informação da programação mensal;
- Compatibilização dos valores dos 2 primeiros meses da geração hidráulica mínima das UHEs Itaipu e Tucuruí de acordo com os utilizados na programação mensal;
- Alteração da potência instalada das UTEs Ponta Negra e Termonorte II conforme Despacho SCG/ANEEL nº 2.632/2021 e REA ANEEL nº 10.559/2021;
- Alteração da potência instalada da UHE Monjolinho conforme OFÍCIO Nº 511/2021–SCG/ANEEL e alteração da vazão efetiva (Qef m^3/s) decorrente da alteração da potência;
- CVU das UTEs Palmeiras de Goiás, Cuiabá, Uruguaiana, Goiânia II, Norteflumínense, Termopernambuco e Termoceará, conforme Despachos SRG/ANEEL nºs 2.767/2021, 2.827/2021, 2.828/2021 e 2.860/2021, 2.944/2021, 2.945/2021 e 2.510/2021 (atualizado pela CCEE);
- Alterações de restrições operativas para as UHEs Jupiá, Furnas, Mascarenhas de Moraes, Manso, Salto Osório, Machadinho, Itá e Chavantes, de acordo com os FSAR-H enviados pelos Agentes responsáveis;
- Restrições de defluências das usinas do Rio São Francisco conforme "Informe Sobre o Planejamento e a Programação da Operação dos Aproveitamentos Hidroelétricos da Bacia do Rio São Francisco no PMO de Outubro de 2021";
- Atualização dos limites de transmissão entre subsistemas segundo Relatório Mensal de Limites de Intercâmbio RT-ONS DPL 0352/2021-rev1.

O conteúdo desta publicação foi produzido pelo ONS com base em dados e informações de conhecimento público. É de responsabilidade exclusiva dos agentes e demais interessados a obtenção de outros dados e informações, a realização de análises, estudos e avaliações para fins de tomada de decisões, definição de estratégias de atuação, assunção de compromissos e obrigações e quaisquer outras finalidades, em qualquer tempo e sob qualquer condição. É proibida a reprodução ou utilização total ou parcial do presente sem a identificação da fonte.

4. ANÁLISE DAS CONDIÇÕES HIDROMETEOROLÓGICAS

A atuação de áreas de instabilidade sobre as regiões Centro-Oeste e Sudeste seguido pela passagem de uma frente fria pela região Sul ocasiona precipitação nas bacias dos rios Jacuí, Uruguai, Iguaçu, e em pontos isolados das bacias dos rios Paranapanema, Tietê, Grande, Paranaíba, Tocantins, do trecho incremental a UHE Itaipu e da calha principal do rio Paraná. (Figura 5).

Figura 5 - Precipitação acumulada prevista pelo modelo ECMWF (ECMWF) para o período de 25/09/2021 a 01/10/2021.

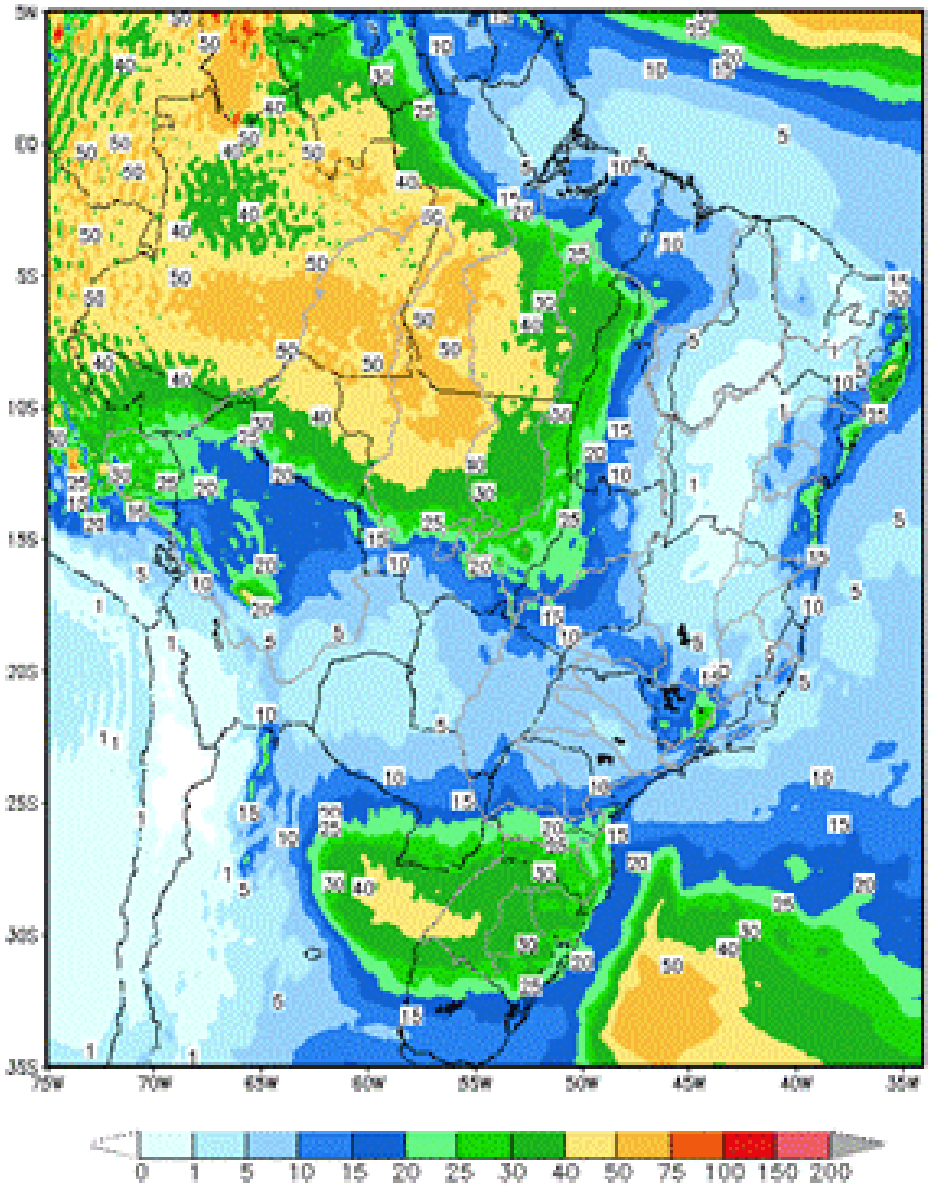

Em comparação com os valores estimados para a semana em curso, prevê-se para a próxima semana operativa recessão nas afluências dos subsistemas Sudeste/Centro-Oeste, Sul e Norte e estabilidade nas afluências do subsistema Nordeste. A previsão mensal para outubro indica a ocorrência de afluências abaixo da média histórica para todos os subsistemas.

O conteúdo desta publicação foi produzido pelo ONS com base em dados e informações de conhecimento público. É de responsabilidade exclusiva dos agentes e demais interessados a obtenção de outros dados e informações, a realização de análises, estudos e avaliações para fins de tomada de decisões, definição de estratégias de atuação, assunção de compromissos e obrigações e quaisquer outras finalidades, em qualquer tempo e sob qualquer condição. É proibida a reprodução ou utilização total ou parcial do presente sem a identificação da fonte.

Tabela 2 – Previsão de ENAs do PMO de Outubro/2021

PMO de Outubro/2021 - ENAs previstas				
Subsistema	25/09 a 01/10/2021		Mês de outubro	
	MWmed	%MLT	MWmed	%MLT
SE/CO	10.139	50	13.395	57
S	7.163	60	12.396	93
NE	1.279	43	1.433	44
N	1.523	66	1.558	65

5. PREVISÃO DE CARGA

As projeções de carga para o mês de outubro/21 levaram em consideração a permanência do setor industrial em modo de expansão apesar da suposta restrição de demanda levada pelos ajustes dos preços de venda em virtude do aumento de custo, ocasionado pela escassez global de matérias-primas e a depreciação do real. Esse desempenho, segundo o Índice Gerente de Compras (PMI) do setor industrial da IHS Markit para o Brasil de agosto/21, está sendo sustentado nas três grandes áreas do setor industrial — bens de consumo, intermediários e de investimento. Além disso, a recuperação do setor serviços em virtude do aumento da mobilidade e a diminuição das restrições para conter a disseminação da COVID-19 também foram considerados. Os efeitos na carga referentes as ações para redução voluntária de consumo e o aumento da bandeira tarifária serão acompanhados/avaliados para que sejam considerados, se necessário, nas revisões semanais.

Para a próxima semana operativa as sinalizações meteorológicas indicam a manutenção do comportamento observado na semana em curso para todas as regiões do Brasil, onde foram observadas temperaturas elevadas nas capitais dos Subsistema Sudeste/Centro-Oeste, Nordeste e Norte, enquanto as capitais dos subsistemas Sul foram observadas temperaturas mais amenas. Destaca-se a previsão de ocorrência de precipitação em todos os dias da próxima semana operativa em Manaus.

As taxas de crescimento previstas para o mês de outubro em relação ao mesmo mês do ano anterior, são de 0,4% para os subsistemas Sudeste/Centro-Oeste, 1,6% para o subsistema Sul, 3,5% no Nordeste e 2,7% no subsistema do Norte.

Tabela 3 – Evolução da carga do PMO de Outubro 2021

Subsistema	CARGA SEMANAL (MWmed)						CARGA MENSAL (MWmed)	
	1ª Sem	2ª Sem	3ª Sem	4ª Sem	5ª Sem	6ª Sem	out/21	Var. (%) out/21 -> out/20
SE/CO	41.298	41.888	40.650	42.175	42.192	40.621	41.641	0,4%
Sul	11.600	12.091	11.887	12.168	12.207	11.868	12.058	1,6%
Nordeste	12.080	12.260	11.975	12.319	12.346	12.000	12.206	3,5%
Norte	6.354	6.253	6.099	6.253	6.246	6.075	6.208	2,7%
SIN	71.332	72.492	70.611	72.915	72.991	70.564	72.113	1,3%

O conteúdo desta publicação foi produzido pelo ONS com base em dados e informações de conhecimento público. É de responsabilidade exclusiva dos agentes e demais interessados a obtenção de outros dados e informações, a realização de análises, estudos e avaliações para fins de tomada de decisões, definição de estratégias de atuação, assunção de compromissos e obrigações e quaisquer outras finalidades, em qualquer tempo e sob qualquer condição. É proibida a reprodução ou utilização total ou parcial do presente sem a identificação da fonte.

6. PRINCIPAIS RESULTADOS

6.1. CUSTO MARGINAL DE OPERAÇÃO (CMO)

A tabela a seguir apresenta o CMO, por subsistema e patamar de carga para próxima semana operativa.

Tabela 4 – CMO por patamar de carga

Patamares de Carga	CMO (R$/MWh)			
	SE/CO	S	NE	N
Pesada	541,41	541,41	541,41	541,41
Média	541,40	541,40	541,40	541,40
Leve	524,52	524,52	524,52	524,52
Média Semanal	533,36	533,36	533,36	533,36

Na figura a seguir é apresentada a evolução do CMO médio semanal ao longo deste PMO.

Figura 6 – Evolução semanal do CMO

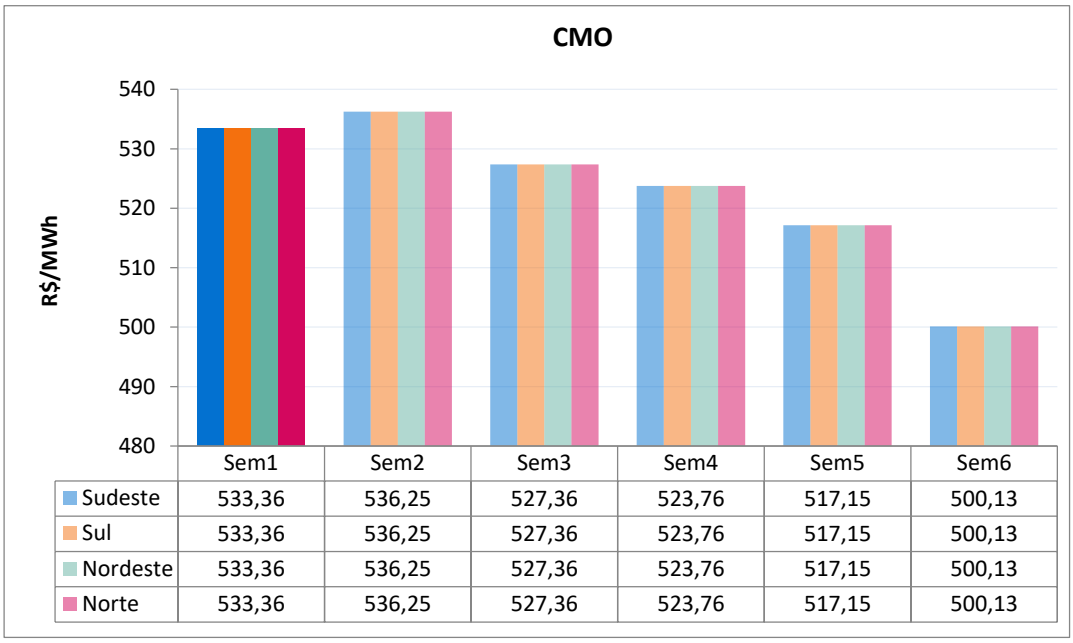

6.2. POLÍTICA DE OPERAÇÃO ENERGÉTICA

Para esta semana operativa, está prevista a seguinte política de intercâmbio de energia entre regiões:

Região SE/CO → Geração minimizada de acordo com os condicionantes hidráulicos e utilizada para fechamento do balanço energético do SIN.

Região Sul → Exploração das disponibilidades energéticas, respeitando-se os limites elétricos vigentes.

Região NE → Início da redução da geração eólica. Manutenção da exploração das disponibilidades energéticas, respeitando-se os limites elétricos vigente.

Região Norte → Redução da exploração das disponibilidades energéticas, respeitando-se os limites elétricos vigentes.

O conteúdo desta publicação foi produzido pelo ONS com base em dados e informações de conhecimento público. É de responsabilidade exclusiva dos agentes e demais interessados a obtenção de outros dados e informações, a realização de análises, estudos e avaliações para fins de tomada de decisões, definição de estratégias de atuação, assunção de compromissos e obrigações e quaisquer outras finalidades, em qualquer tempo e sob qualquer condição. É proibida a reprodução ou utilização total ou parcial do presente sem a identificação da fonte.

7. GERAÇÃO TÉRMICA

A Figura 7 apresenta, para cada subsistema, o despacho térmico por modalidade indicado pelo Decomp para a próxima semana operativa.

Figura 7 – Geração térmica para a próxima semana operativa

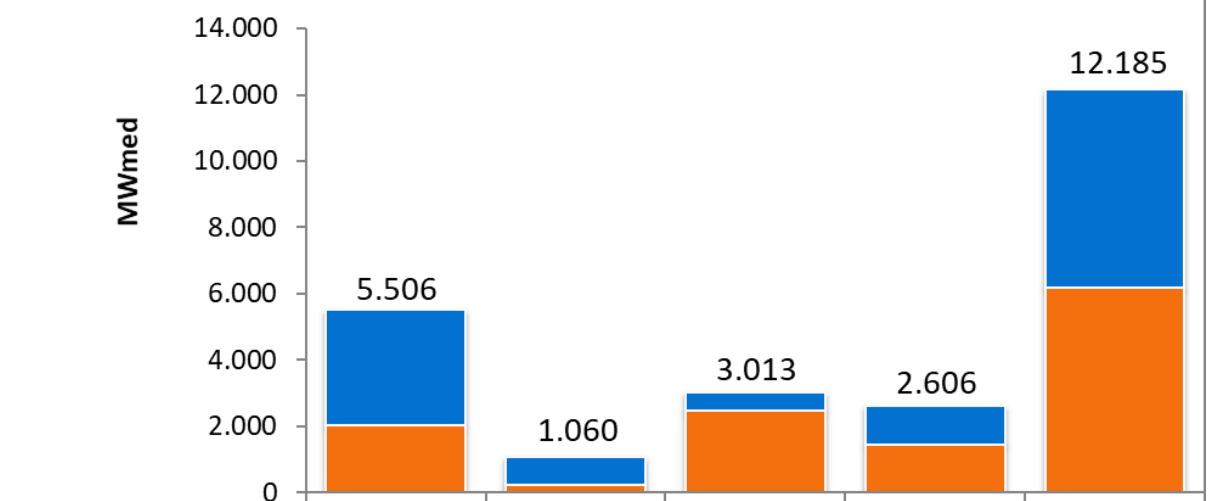

	SE/CO	SUL	NE	NORTE	SIN
RESTRIÇÃO ELÉTRICA	0	0	0	0	0
INFLEXIBILIDADE	3475	819	533	1165	5992
ORDEM DE MÉRITO	2031	241	2480	1441	6193

Na tabela abaixo segue a Indicação de despacho antecipado por ordem de mérito de custo para a semana de 27/11/2021 a 03/12/2021.

Tabela 5 – UTEs com contrato de combustível GNL

UTE			Benefício (R$/MWh)		
Nome	Cod	CVU (R$/MWh)	Carga Pesada	Carga Média	Carga Leve
SANTA CRUZ	86	284,35	420,35 (1)	420,35 (1)	420,34 (1)
LUIZORMELO	15	438,83	420,35 (2)	420,35 (2)	420,34 (2)
PSERGIPE I	224	310,18	417,69 (1)	417,04 (1)	416,14 (1)

(1) Comandado o despacho antecipado por ordem de mérito de custo nesse patamar

(2) NÃO foi comandado o despacho antecipado por ordem de mérito de custo nesse patamar

Assim sendo, há previsão de despacho antecipado por ordem de mérito de custo para as UTE Santa Cruz e Porto Sergipe I, para a semana de 27/11 a 03/12/2021.

Ressalta-se que, embora a UTE Luiz O. R. Melo não esteja despachada antecipadamente por ordem de mérito de custo, o ONS comanda seu despacho antecipado, para a semana de 27/11 a 03/12/2021, por garantia energética.

O conteúdo desta publicação foi produzido pelo ONS com base em dados e informações de conhecimento público. É de responsabilidade exclusiva dos agentes e demais interessados a obtenção de outros dados e informações, a realização de análises, estudos e avaliações para fins de tomada de decisões, definição de estratégias de atuação, assunção de compromissos e obrigações e quaisquer outras finalidades, em qualquer tempo e sob qualquer condição. É proibida a reprodução ou utilização total ou parcial do presente sem a identificação da fonte.

8. IMPORTAÇÃO DE ENERGIA DA REPÚBLICA ORIENTAL DO URUGUAI

8.1. República Oriental do Uruguai

Para a próxima semana operativa, foram declaradas as seguintes ofertas de importação de energia da República Oriental do Uruguai para o Sistema Interligado Nacional - SIN através das conversoras de Rivera (70 MW) e Melo (500 MW).

- **Eletrobras**

Tabela 6 – Energia ofertada para importação

	Oferta de Energia para a Semana de 25/09 a 01/10 (MWmed)				
	Bloco 1	Bloco 2	Bloco 3	Bloco 4	Total
Carga Pesada	100	50	85	50	285
Carga Média	100	50	85	50	285
Carga Leve	100	50	85	50	285
CVU (R$/MWh)	979,70	1369,94	1739,61	1930,70	

- **Enel**

Conforme declaração do agente, esta importação poderá ser realizada exclusivamente pela conversora Melo.

Tabela 7 – Energia ofertada para importação

	Oferta de Energia para a Semana de 25/09 a 01/10 (MWmed)				
	Bloco 1	Bloco 2	Bloco 3	Bloco 4	Total
Carga Pesada	100	50	85	50	285
Carga Média	100	50	85	50	285
Carga Leve	100	50	85	50	285
CVU (R$/MWh)	986,86	1376,34	1741,24	1933,29	

8.2. República da Argentina

- **Enel**

Para a próxima semana operativa, foi declarada a seguinte oferta de importação de energia da República da Argentina para o SIN através das conversoras de Garabi 1 (1.100 MW) e Garabi 2 (1.100 MW).

Tabela 8 – Energia ofertada para importação

	Oferta de Energia para a Semana de 25/09 a 01/10 (MWmed)				
	Bloco 1	Bloco 2	Bloco 3	Bloco 4	Total
Carga Pesada	200	200	600	1200	2.200
Carga Média	200	200	600	1200	2.200
Carga Leve	200	200	600	1200	2.200
CVU (R$/MWh)	1.395,18	1.523,84	1.843,16	1.971,23	

Nota: Detalhes sobre a importação de energia vide Portaria Nº 339, de 15 de agosto de 2018 disponível em: http://pesquisa.in.gov.br/imprensa/jsp/visualiza/index.jsp?data=17/08/2018&jornal=515&pagina=60&totalArquivos=136

O conteúdo desta publicação foi produzido pelo ONS com base em dados e informações de conhecimento público. É de responsabilidade exclusiva dos agentes e demais interessados a obtenção de outros dados e informações, a realização de análises, estudos e avaliações para fins de tomada de decisões, definição de estratégias de atuação, assunção de compromissos e obrigações e quaisquer outras finalidades, em qualquer tempo e sob qualquer condição. É proibida a reprodução ou utilização total ou parcial do presente sem a identificação da fonte.

9. ARMAZENAMENTOS OPERATIVOS

Para uma melhor avaliação de diversos cenários hidrometeorológicos, notadamente, aqueles de curto prazo e suas influências nas previsões de vazões nos subsistemas, os resultados deste PMO contemplam cenários de afluências visando melhor representar a ocorrência de precipitação e, consequentemente, seus efeitos sobre as afluências e armazenamentos.

Além dos resultados associados ao valor esperado das previsões de afluências, as simulações operativas também foram realizadas com os limites superior e inferior das previsões de afluências. Apresentamos a seguir os resultados obtidos com a aplicação dos diferentes cenários de afluência.

Tabela 9 – Previsão de ENA dos cenários de sensibilidade

Subsistema	ENERGIAS NATURAIS AFLUENTES					
	Previsão Mensal					
	LI		VE		LS	
	(MWmed)	%MLT	(MWmed)	%MLT	(MWmed)	%MLT
SE/CO	9.479	**40**	13.395	**57**	17.380	**73**
Sul	5.865	**44**	12.396	**93**	18.969	**142**
Nordeste	1.027	**32**	1.433	**44**	1.845	**57**
Norte	1.252	**52**	1.558	**65**	1.880	**78**

Tabela 10 – Previsão de %EARmáx para o final do mês

Subsistema	% EARmáx 24/09	% EARmáx - 31/10		
	NÍVEL INICIAL	NÍVEL PMO		
	VE	LI	VE	LS
SE/CO	18,4	11,5	12,6	13,2
Sul	30,9	18,7	35,6	54,4
Nordeste	42,2	25,0	26,1	29,4
Norte	62,9	44,1	42,9	44,8

–

O conteúdo desta publicação foi produzido pelo ONS com base em dados e informações de conhecimento público. É de responsabilidade exclusiva dos agentes e demais interessados a obtenção de outros dados e informações, a realização de análises, estudos e avaliações para fins de tomada de decisões, definição de estratégias de atuação, assunção de compromissos e obrigações e quaisquer outras finalidades, em qualquer tempo e sob qualquer condição. É proibida a reprodução ou utilização total ou parcial do presente sem a identificação da fonte.

10. RESERVATÓRIOS EQUIVALENTES DE ENERGIA

A seguir são apresentadas as previsões de Energia Natural Afluente para a próxima semana operativa e para o mês de outubro, bem como as previsões de Energia Armazenada nos Reservatórios Equivalentes de Energia – REE, deste PMO.

Tabela 11 – Previsão de ENA por REE

Valor Esperado das Energias Naturais Afluentes				
REE	Previsão Semanal		Previsão Mensal	
	25/09/2021 a 01/10/2021		out/21	
	(MWmed)	%MLT	(MWmed)	%MLT
Sudeste	1.246	49	1.748	56
Madeira	1.415	77	1.804	85
Teles Pires	524	74	711	84
Itaipu	1.554	56	2.070	63
Paraná	4.566	44	5.749	49
Paranapanema	831	39	1.290	51
Sul	5.153	74	8.638	122
Iguaçu	2.010	40	3.758	60
Nordeste	1.279	43	1.433	44
Norte	777	51	905	53
Belo Monte	132	34	165	38
Manaus	641	157	507	187

Tabela 12 – Previsão de %EARmáx por REE

% Energia Armazenável Máxima		
REE	Previsão Semanal	Previsão Mensal
	01-out	31-out
	(%EARmáx)	(%EARmáx)
Sudeste	24,5	19,0
Madeira	31,9	18,9
Teles Pires	50,5	24,1
Itaipu	15,5	11,1
Paraná	13,1	8,8
Paranapanema	27,3	31,7
Sul	45,6	57,7
Iguaçu	14,3	15,4
Nordeste	39,2	26,1
Norte	58,2	41,5
Belo Monte	98,8	91,4
Manaus	73,5	66,6

O conteúdo desta publicação foi produzido pelo ONS com base em dados e informações de conhecimento público. É de responsabilidade exclusiva dos agentes e demais interessados a obtenção de outros dados e informações, a realização de análises, estudos e avaliações para fins de tomada de decisões, definição de estratégias de atuação, assunção de compromissos e obrigações e quaisquer outras finalidades, em qualquer tempo e sob qualquer condição. É proibida a reprodução ou utilização total ou parcial do presente sem a identificação da fonte.

11. DESPACHO TÉRMICO POR MODALIDADE, PATAMAR DE CARGA E USINA

Nas tabelas abaixo, a diferenciação entre geração por inflexibilidade e por ordem de mérito tem caráter informativo, com o objetivo de detalhar a informação de inflexibilidade enviada pelos respectivos agentes para o PMO. Ressalta-se que nas etapas de Programação Diária e Tempo Real, o montante despachado nas usinas termelétricas indicadas por ordem de mérito é plenamente intitulado como ordem de mérito.

REGIÃO SUDESTE/CENTRO-OESTE																	
Térmicas Potência (MW)	Combustível	CVU (R$/MWh)	Inflexibilidade			Ordem de Mérito			Total Mérito e INFL.			Razão Elétrica			Total UTE		
			P	M	L	P	M	L	P	M	L	P	M	L	P	M	L
ATLAN_CSA (255)	Resíduos	0,00	170,0	170,0	170,0				170,0	170,0	170,0				170,0	170,0	170,0
ANGRA 2 (1350)	Nuclear	20,12	1350,0	1350,0	1350,0	0,0	0,0	0,0	1350,0	1350,0	1350,0				1350,0	1350,0	1350,0
ANGRA 1 (640)	Nuclear	31,17	640,0	640,0	640,0	0,0	0,0	0,0	640,0	640,0	640,0				640,0	640,0	640,0
NORTEFLU 1 (400)	Gás	81,36	400,0	400,0	400,0	0,0	0,0	0,0	400,0	400,0	400,0				400,0	400,0	400,0
NORTEFLU 2 (100)	Gás	94,33	100,0	100,0	100,0	0,0	0,0	0,0	100,0	100,0	100,0				100,0	100,0	100,0
O.PINTADA (50)	Biomassa	112,47	7,0	7,0	7,0	43,0	43,0	43,0	50,0	50,0	50,0				50,0	50,0	50,0
UTE STA VI (41)	Biomassa	121,49	13,0	13,0	13,0	28,4	28,4	28,4	41,4	41,4	41,4				41,4	41,4	41,4
PREDILECTA (5)	Biomassa	158,95	1,0	1,0	1,0	4,0	4,0	4,0	5,0	5,0	5,0				5,0	5,0	5,0
NORTEFLU 3 (200)	Gás	178,57	200,0	200,0	200,0	0,0	0,0	0,0	200,0	200,0	200,0				200,0	200,0	200,0
ATLANTICO (235)	Resíduos	206,08	218,7	218,7	218,7	0,0	0,0	0,0	218,7	218,7	218,7				218,7	218,7	218,7
T.LAGOAS (350)	Gás	263,28				225,5	225,5	225,5	225,5	225,5	225,5				225,5	225,5	225,5
BAIXADA FL (530)	Gás	280,55				520,0	520,0	520,0	520,0	520,0	520,0				520,0	520,0	520,0
JUIZ DE FO (87)	Gás	283,74				75,0	75,0	75,0	75,0	75,0	75,0				75,0	75,0	75,0
SANTA CRUZ (500)	GNL	284,35				126,0	92,1	35,0	126,0	92,1	35,0				126,0	92,1	35,0
ST.CRUZ 34 (436)	Óleo	310,41															
TERMORIO (1036)	Gás	331,05	175,0	175,0	175,0	493,9	493,9	493,9	668,9	668,9	668,9				668,9	668,9	668,9
CUBATAO (216)	Gás	358,39	200,0	200,0	200,0	9,0	9,0	9,0	209,0	209,0	209,0				209,0	209,0	209,0
SEROPEDICA (386)	Gás	411,72				353,5	353,5	353,5	353,5	353,5	353,5				353,5	353,5	353,5
LUIZORMELO (204)	GNL	438,83				204,0	204,0	204,0	204,0	204,0	204,0				204,0	204,0	204,0
PIRAT.12 O (200)	Gás	470,34															
NPIRATINGA (572)	Gás	548,04															
UTE GNA I (1338)	Gás	552,56															
NORTEFLU 4 (127)	Gás	611,96															
T.MACAE (929)	Gás	739,94															
TNORTE 2 (349)	Óleo	910,86															
IBIRITE (226)	Gás	959,34															
VIANA (175)	Óleo	962,90															
CAMPOS (25)	Gás	978,10															
DAIA (44)	Diesel	1021,09															
GOIANIA 2 (140)	Diesel	1423,43															
XAVANTES (54)	Diesel	1467,26															
PALMEIR_GO (176)	Diesel	1475,51															
CUIABA CC (529)	Gás	1831,81															
W.ARJONA O	Diesel	2042,39															
W.ARJONA (177)	Gás	2443,68															
TOTAL SE/CO (12082)			3474,7	3474,7	3474,7	2082,3	2048,4	1991,3	5557,0	5523,1	5466,0	0,0	0,0	0,0	5557,0	5523,1	5466,0

REGIÃO SUL																	
Térmicas Potência (MW)	Combustível	CVU (R$/MWh)	Inflexibilidade			Ordem de Mérito			Total Mérito e INFL.			Razão Elétrica			Total UTE		
			P	M	L	P	M	L	P	M	L	P	M	L	P	M	L
PAMPA SUL (345)	Carvão	69,75				0,0	0,0	0,0	0,0	0,0	0,0				0,0	0,0	0,0
SAO SEPE (8)	Biomassa	87,75	7,0	7,0	7,0	0,0	0,0	0,0	7,0	7,0	7,0				7,0	7,0	7,0
CANDIOTA_3 (350)	Carvão	92,86	310,0	310,0	310,0	0,0	0,0	0,0	310,0	310,0	310,0				310,0	310,0	310,0
J.LACER. C (363)	Carvão	229,27	200,0	200,0	200,0	130,0	130,0	130,0	330,0	330,0	330,0				330,0	330,0	330,0
J.LACER. B (262)	Carvão	271,21	160,0	160,0	160,0	60,0	60,0	60,0	220,0	220,0	220,0				220,0	220,0	220,0
J.LAC. A2 (132)	Carvão	278,38	70,0	70,0	70,0	40,0	40,0	40,0	110,0	110,0	110,0				110,0	110,0	110,0
J.LAC. A1 (100)	Carvão	304,61	70,0	70,0	70,0	10,0	10,0	10,0	80,0	80,0	80,0				80,0	80,0	80,0
MADEIRA (4)	Biomassa	333,15	2,0	2,0	2,0	1,0	1,0	1,0	3,0	3,0	3,0				3,0	3,0	3,0
FIGUEIRA (20)	Carvão	475,68				0,0	0,0	0,0	0,0	0,0	0,0				0,0	0,0	0,0
CANOAS (249)	Diesel	698,14															
ARAUCARIA (484)	Gás	706,35															
URUGUAIANA (640)	Gás	1589,58															
TOTAL SUL (2957)			819,0	819,0	819,0	241,0	241,0	241,0	1060,0	1060,0	1060,0	0,0	0,0	0,0	1060,0	1060,0	1060,0

O conteúdo desta publicação foi produzido pelo ONS com base em dados e informações de conhecimento público. É de responsabilidade exclusiva dos agentes e demais interessados a obtenção de outros dados e informações, a realização de análises, estudos e avaliações para fins de tomada de decisões, definição de estratégias de atuação, assunção de compromissos e obrigações e quaisquer outras finalidades, em qualquer tempo e sob qualquer condição. É proibida a reprodução ou utilização total ou parcial do presente sem a identificação da fonte.

REGIÃO NORDESTE

Térmicas Potência (MW)	Combustível	CVU (R$/MWh)	Inflexibilidade			Ordem de Mérito			Total Mérito e INFL.			Razão Elétrica			Total UTE		
			P	M	L	P	M	L	P	M	L	P	M	L	P	M	L
ALTOS (13)	Diesel	---															
ARACATI (11)	Diesel	---															
BATURITE (11)	Diesel	---															
C.MAIOR (13)	Diesel	---															
CAUCAIA (15)	Diesel	---															
CRATO (13)	Diesel	---															
IGUATU (15)	Diesel	---															
JUAZEIRO N (15)	Diesel	---															
MARAMBAIA (13)	Diesel	---															
NAZARIA (13)	Diesel	---															
PECEM (15)	Diesel	---															
ERB CANDEI (17)	Biomassa	87,81				0,0	0,0	0,0	0,0	0,0	0,0				0,0	0,0	0,0
PROSPERIDA (28)	Gás	165,61				28,0	28,0	28,0	28,0	28,0	28,0				28,0	28,0	28,0
TERMOPE (533)	Gás	178,07	532,7	532,7	532,7	0,0	0,0	0,0	532,7	532,7	532,7				532,7	532,7	532,7
FORTALEZA (327)	Gás	245,46				326,6	326,6	326,6	326,6	326,6	326,6				326,6	326,6	326,6
PSERGIPE I (1516)	GNL	310,18				1040,0	1040,0	1040,0	1040,0	1040,0	1040,0				1040,0	1040,0	1040,0
P.PECEM2 (365)	Carvão	443,79				365,0	365,0	365,0	365,0	365,0	365,0				365,0	365,0	365,0
P.PECEM1 (720)	Carvão	447,60				720,0	720,0	720,0	720,0	720,0	720,0				720,0	720,0	720,0
SYKUE I (30)	Biomassa	510,12				0,0	0,0	0,0	0,0	0,0	0,0				0,0	0,0	0,0
BAHIA_1 (31)	Óleo	819,91															
PERNAMBU_3 (201)	Óleo	831,02															
MARACANAU (168)	Óleo	937,10															
TERMOCABO (50)	Óleo	951,07															
TERMONE (171)	Óleo	954,27															
TERMOPB (171)	Óleo	954,27															
CAMPINA_GR (169)	Óleo	962,92															
SUAPE II (381)	Óleo	985,73															
POTIGUAR_3 (66)	Diesel	1004,47															
POTIGUAR (53)	Diesel	1004,48															
VALE ACU (368)	Gás	1009,19															
AREMBEPE (150)	Óleo	1023,93															
MURICY (147)	Óleo	1023,93															
T.BAHIA (186)	Gás	1042,36															
GLOBAL I (149)	Óleo	1090,85															
GLOBAL II (149)	Óleo	1090,85															
PETROLINA (136)	Óleo	1123,39															
PAU FERRO (94)	Diesel	1137,10															
TERMOMANAU (143)	Diesel	1137,10															
TERMOCEARA (223)	Diesel	1601,80															
TOTAL NE (6889)			532,7	532,7	532,7	1439,6	1439,6	1439,6	1972,3	1972,3	1972,3	####	####	####	3012,3	3012,3	3012,3

REGIÃO NORTE

Térmicas Potência (MW)	Combustível	CVU (R$/MWh)	Inflexibilidade			Ordem de Mérito			Total Mérito e INFL.			Razão Elétrica			Total UTE		
			P	M	L	P	M	L	P	M	L	P	M	L	P	M	L
C. ROCHA (85)	Gás	0,00	65,0	65,0	65,0				65,0	65,0	65,0				65,0	65,0	65,0
JARAQUI (75)	Gás	0,00	63,0	63,0	63,0				63,0	63,0	63,0				63,0	63,0	63,0
MANAUARA (67)	Gás	0,00	64,5	64,5	64,5				64,5	64,5	64,5				64,5	64,5	64,5
PONTA NEGR (73)	Gás	0,00	64,0	64,0	64,0				64,0	64,0	64,0				64,0	64,0	64,0
TAMBAQUI (93)	Gás	0,00	63,0	63,0	63,0				63,0	63,0	63,0				63,0	63,0	63,0
MARANHAO3 (519)	Gás	85,72	490,0	515,8	513,0	0,0	0,0	0,0	490,0	515,8	513,0				490,0	515,8	513,0
APARECIDA (166)	Gás	128,41	75,0	75,0	75,0	71,0	71,0	68,4	146,0	146,0	143,4				146,0	146,0	143,4
UTE MAUA 3 (591)	Gás	128,41	264,0	264,0	264,0	115,0	115,0	115,0	379,0	379,0	379,0				379,0	379,0	379,0
PARNAIB_IV (56)	Gás	151,69				56,3	56,3	56,3	56,3	56,3	56,3				56,3	56,3	56,3
N.VEN2_L22 (27)	Gás	232,27				27,0	27,0	27,0	27,0	27,0	27,0				27,0	27,0	27,0
N.VEN2_L7 (151)	Gás	232,27				143,0	150,3	149,6	143,0	150,3	149,6				143,0	150,3	149,6
MARAN_VL_7 (336)	Gás	260,71				323,9	335,1	333,9	323,9	335,1	333,9				323,9	335,1	333,9
MARANIVL_7 (336)	Gás	260,71				323,8	335,1	333,9	323,8	335,1	333,9				323,8	335,1	333,9
MARAN_VL22 (1)	Gás	260,72				1,1	1,1	1,1	1,1	1,1	1,1				1,1	1,1	1,1
MARANIVL22 (1)	Gás	260,72				1,1	1,1	1,1	1,1	1,1	1,1				1,1	1,1	1,1
P. ITAQUI (360)	Carvão	436,76				360,1	360,1	360,1	360,1	360,1	360,1				360,1	360,1	360,1
GERAMAR1 (166)	Óleo	962,88															
GERAMAR2 (166)	Óleo	962,88															
TOTAL NORTE (3271)			1148,5	1174,3	1171,5	1422,3	1452,1	1446,4	2570,8	2626,4	2617,9	0,0	0,0	0,0	2570,8	2626,4	2617,9

O conteúdo desta publicação foi produzido pelo ONS com base em dados e informações de conhecimento público. É de responsabilidade exclusiva dos agentes e demais interessados a obtenção de outros dados e informações, a realização de análises, estudos e avaliações para fins de tomada de decisões, definição de estratégias de atuação, assunção de compromissos e obrigações e quaisquer outras finalidades, em qualquer tempo e sob qualquer condição. É proibida a reprodução ou utilização total ou parcial do presente sem a identificação da fonte.