1. APRESENTAÇÃO

Na semana de 26/03 a 01/04/2022 houve chuva fraca à moderada nas bacias dos rios Jacuí, Uruguai, Iguaçu, no trecho incremental a UHE Itaipu, Paranapanema, Tietê, Paraíba do Sul, Grande e Paranaíba. As bacias hidrográficas da região também apresentaram chuva no decorrer da semana operativa, principalmente nas bacias do rio Madeira, Tocantins e Xingu.

Na semana de 02/04 a 08/04/2022 deve ocorrer chuva nas bacias dos rios Uruguai, Iguaçu, Paranapanema, no trecho incremental a UHE Itaipu e em pontos isolados do Grande e do Paranaíba. As bacias hidrográficas da região Norte permanecem com a condição de pancadas de chuva. Apesar da ocorrência de precipitação, apenas as bacias dos rios Uruguai, Jacuí, Iguaçu, e Paranapanema apresentam precipitação acima da média para o período.

Para a semana operativa de 02/04 a 08/04/2022, houve oferta de energia da República Oriental do Uruguai. De acordo com o Art. 2º da Portaria MME nº 339, de 15 de agosto de 2018, as ofertas para importação de energia não foram consideradas na elaboração do PMO. Para a referida semana, não houve oferta de energia da República da Argentina.

Os valores médios semanais do Custo Marginal de Operação – CMO dos subsistemas do SIN sofreram as seguintes alterações em relação à semana anterior:

- SE/CO: de R$ 42,32/MWh para R$ 40,15/MWh
- Sul: de R$ 42,32/MWh para R$ 40,15/MWh
- Nordeste: de R$ 0,00/MWh para R$ 0,00/MWh
- Norte: de R$ 0,00/MWh para R$ 0,00/MWh

Desde o dia 01/01/2020, o despacho por ordem de mérito é indicado diariamente pelos resultados do modelo DESSEM. Assim, o despacho por ordem de mérito semanal, conforme publicado nesse documento, tem caráter apenas informativo. Da mesma forma, desde o dia 01/01/2021, a formação de preço deixou o formato semanal/patamar de carga e passou a ser horário, de acordo também com os resultados do modelo DESSEM.

2. NOTÍCIAS

Nos dias 28 e 29 de abril será realizada a reunião de elaboração do PMO de Maio de 2022, com transmissão ao vivo através do site do ONS.

Como medida adicional de prevenção ao Coronavírus, o ONS informa que está suspensa, temporariamente, a participação presencial nas reuniões.

O conteúdo desta publicação foi produzido pelo ONS com base em dados e informações de conhecimento público. É de responsabilidade exclusiva dos agentes e demais interessados a obtenção de outros dados e informações, a realização de análises, estudos e avaliações para fins de tomada de decisões, definição de estratégias de atuação, assunção de compromissos e obrigações e quaisquer outras finalidades, em qualquer tempo e sob qualquer condição. É proibida a reprodução ou utilização total ou parcial do presente sem a identificação da fonte.

3. ANÁLISE DAS CONDIÇÕES HIDROMETEOROLÓGICAS

3.1. PREVISÃO PARA A PRÓXIMA SEMANA

No início da próxima semana o avanço de uma frente fria pela região Sul ocasiona chuva com até moderada intensidade nas bacias dos rios Uruguai, Iguaçu, Paranapanema, no trecho incremental a UHE Itaipu e em pontos isolados do Grande e do Paranaíba (Figura 1). As bacias hidrográficas da região Norte permanecem com a condição de pancadas de chuva. Apesar da ocorrência de precipitação, apenas as bacias dos rios Uruguai, Jacuí, Iguaçu, e Paranapanema apresentam precipitação acima da média para o período.

Figura 1 - Precipitação acumulada prevista pelo modelo ECMWF - 01 a 07/04/2022

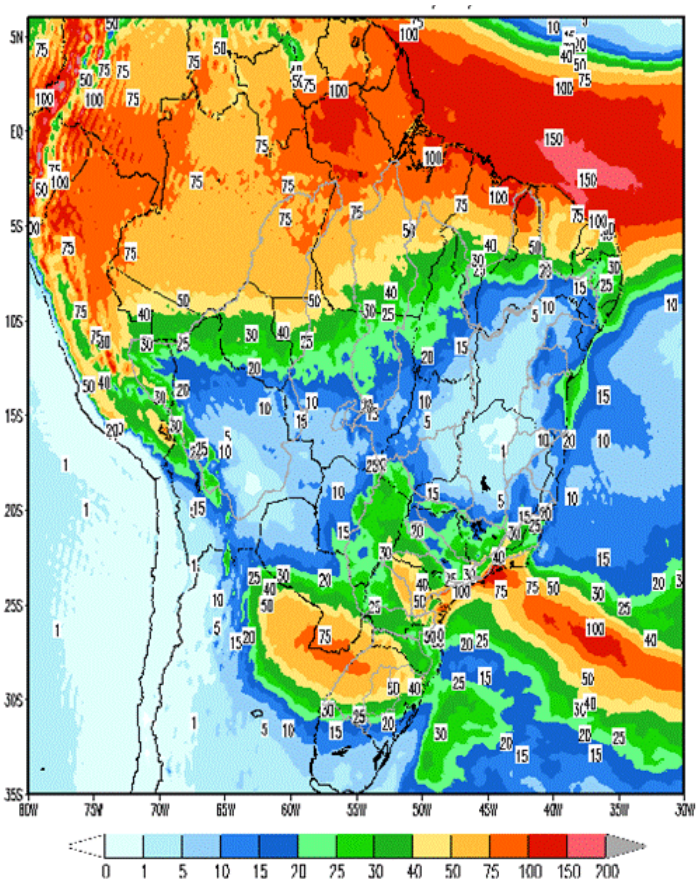

Em comparação com os valores estimados para a semana em curso, prevê-se para a próxima semana operativa recessão nas afluências de todos os subsistemas. A previsão mensal para abril indica a ocorrência de afluências abaixo da média histórica para os subsistemas Sudeste/Centro-Oeste e Nordeste e acima da média histórica para os subsistemas Sul e Norte.

Tabela 1 – Previsão de ENAs da revisão 1 de abril/2022

Revisão 1 do PMO de abril/2022 - ENAs previstas				
Subsistema	02/04 a 08/04/2022		Mês de abril	
	MWmed	%MLT	MWmed	%MLT
SE/CO	44.994	82	39.973	73
S	7.226	111	9.054	140
NE	7.387	64	5.699	49
N	30.352	112	28.701	106

O conteúdo desta publicação foi produzido pelo ONS com base em dados e informações de conhecimento público. É de responsabilidade exclusiva dos agentes e demais interessados a obtenção de outros dados e informações, a realização de análises, estudos e avaliações para fins de tomada de decisões, definição de estratégias de atuação, assunção de compromissos e obrigações e quaisquer outras finalidades, em qualquer tempo e sob qualquer condição. É proibida a reprodução ou utilização total ou parcial do presente sem a identificação da fonte.

4. PREVISÃO DE CARGA

A desaceleração de diversos segmentos da economia tem se refletido diretamente na carga do SIN durante os primeiros meses de 2022. A indústria vem enfrentando desaceleração da demanda acompanhada ainda de persistência dos gargalos produtivos que pressionam os custos. Com a oitava queda consecutiva, o resultado do indicador de confiança da indústria referente ao mês de março corrobora com a afirmação acima. Apesar da desaceleração desses indicadores, as altas temperaturas observadas no período, principalmente nas regiões Sudeste/Centro-Oeste e Sul durante alguns dias do mês, provocaram a elevação da carga, atenuando os efeitos dos fatores citados anteriormente.

As sinalizações meteorológicas indicam para a próxima semana em todas as regiões do país, condições de estabilidade em relação às temperaturas médias elevadas observadas durante a semana em curso. Para o período previsto ainda cabe destacar a expectativa de duas passagens de frentes frias, uma nos primeiros dias da semana e outra ao final do período previsto, nas capitais dos subsistemas Sul e Sudeste/Centro-Oeste, ambas ocasionando declínios de temperatura e chuva. Outro fator que merece destaque é a manutenção de ocorrência de maiores totais de precipitação na costa Norte do Nordeste e nas capitais do subsistema Norte.

Para o mês de abril/22 são previstas taxas de crescimento de 7,8%, 1,8% e 0,7% para os subsistemas Sudeste/Centro-Oeste, Sul e Nordeste, respectivamente. Para o subsistema Norte é esperado uma variação negativa de 4,8%, em função da redução parcial da carga de um consumidor livre da rede básica na região.

Tabela 2 – Evolução da carga do PMO de abril 2022

Subsistema	CARGA SEMANAL (MWmed)						CARGA MENSAL (MWmed)	
	1ª Sem	2ª Sem	3ª Sem	4ª Sem	5ª Sem	6ª Sem	abr/22	Var. (%) abr/22 -> abr/21
SE/CO	43.763	43.328	42.424	41.981	43.221	43.137	42.786	7,8%
Sul	11.904	12.112	12.043	11.905	12.648	12.587	12.181	1,8%
Nordeste	11.148	11.367	11.183	11.149	11.376	11.378	11.268	0,7%
Norte	5.670	5.777	5.713	5.696	5.812	5.817	5.749	-4,8%
SIN	72.485	72.584	71.363	70.731	73.057	72.919	71.984	4,5%

O conteúdo desta publicação foi produzido pelo ONS com base em dados e informações de conhecimento público. É de responsabilidade exclusiva dos agentes e demais interessados a obtenção de outros dados e informações, a realização de análises, estudos e avaliações para fins de tomada de decisões, definição de estratégias de atuação, assunção de compromissos e obrigações e quaisquer outras finalidades, em qualquer tempo e sob qualquer condição. É proibida a reprodução ou utilização total ou parcial do presente sem a identificação da fonte.

5. PRINCIPAIS RESULTADOS

5.1. CUSTO MARGINAL DE OPERAÇÃO (CMO)

A tabela a seguir apresenta o CMO, por subsistema e patamar de carga para próxima semana operativa.

Tabela 3 – CMO por patamar de carga

Patamares de Carga	CMO (R$/MWh)			
	SE/CO	S	NE	N
Pesada	41,55	41,55	0,00	0,00
Média	41,54	41,54	0,00	0,00
Leve	38,62	38,62	0,00	0,00
Média Semanal	40,15	40,15	0,00	0,00

Na figura a seguir é apresentada a evolução do CMO médio semanal ao longo deste PMO.

Figura 2 – Evolução semanal do CMO

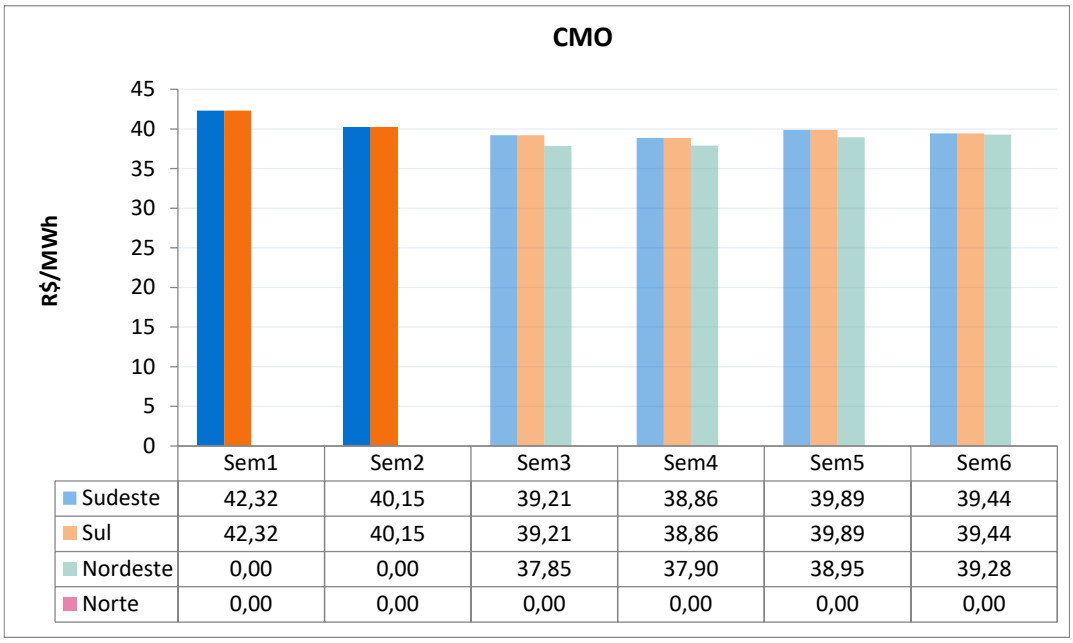

	Sem1	Sem2	Sem3	Sem4	Sem5	Sem6
Sudeste	42,32	40,15	39,21	38,86	39,89	39,44
Sul	42,32	40,15	39,21	38,86	39,89	39,44
Nordeste	0,00	0,00	37,85	37,90	38,95	39,28
Norte	0,00	0,00	0,00	0,00	0,00	0,00

5.2. POLÍTICA DE OPERAÇÃO ENERGÉTICA

Para esta semana operativa, está prevista a seguinte política de intercâmbio de energia entre regiões:

Região SE/CO → Geração de acordo com os condicionantes hidráulicos, a exportação para Sul e preservação dos reservatórios.

Região Sul → Geração hidráulica visando a preservação dos armazenamentos.

Região NE → Manutenção da exploração das disponibilidades energéticas, respeitando-se as restrições hidráulicas e os limites elétricos vigentes.

Região Norte → Exploração das disponibilidades energéticas, respeitando-se os limites elétricos vigentes.

O conteúdo desta publicação foi produzido pelo ONS com base em dados e informações de conhecimento público. É de responsabilidade exclusiva dos agentes e demais interessados a obtenção de outros dados e informações, a realização de análises, estudos e avaliações para fins de tomada de decisões, definição de estratégias de atuação, assunção de compromissos e obrigações e quaisquer outras finalidades, em qualquer tempo e sob qualquer condição. É proibida a reprodução ou utilização total ou parcial do presente sem a identificação da fonte.

6. ANÁLISE DA VARIAÇÃO SEMANAL DO CMO

Esta análise visa identificar os principais parâmetros cujas atualizações impactaram os CMO deste PMO, em comparação com os valores obtidos na última revisão.

Foram realizados 8 estudos, onde o caso inicial foi construído com base nos dados oficiais da última revisão deste PMO. Neste primeiro estudo, denominado de "previsão perfeita", a partida dos reservatórios foi estimada conforme indicado para esta semana na última revisão.

O segundo estudo foi realizado com os dados do caso inicial sendo substituída a previsão de vazões.

A partir do conjunto de dados do segundo estudo foram elaborados os demais casos em que foram atualizadas, sequencialmente, as seguintes informações: níveis de partida dos reservatórios, previsão de carga, disponibilidade das usinas térmicas e hidráulicas, restrições de limites de intercâmbio, restrições hidráulicas e, por fim, os demais dados que compõem toda informação referente a atual revisão.

Os custos marginais de operação dos subsistemas Sudeste/Centro-Oeste e Sul estão acoplados e são apresentados na Figura 3. Os valores do CMO desta revisão estão estáveis em relação aos da semana anterior.

Os custos marginais dos subsistemas Nordeste e Norte estão acoplados entre si e desacoplados com os demais subsistemas do SIN devido ao atingimento dos limites de transmissão de exportação de energia. Observa-se a manutenção do CMO desses subsistemas em relação aos resultados da revisão anterior.

Figura 3 – Análise da variação do CMO nos subsistemas SE/CO e S

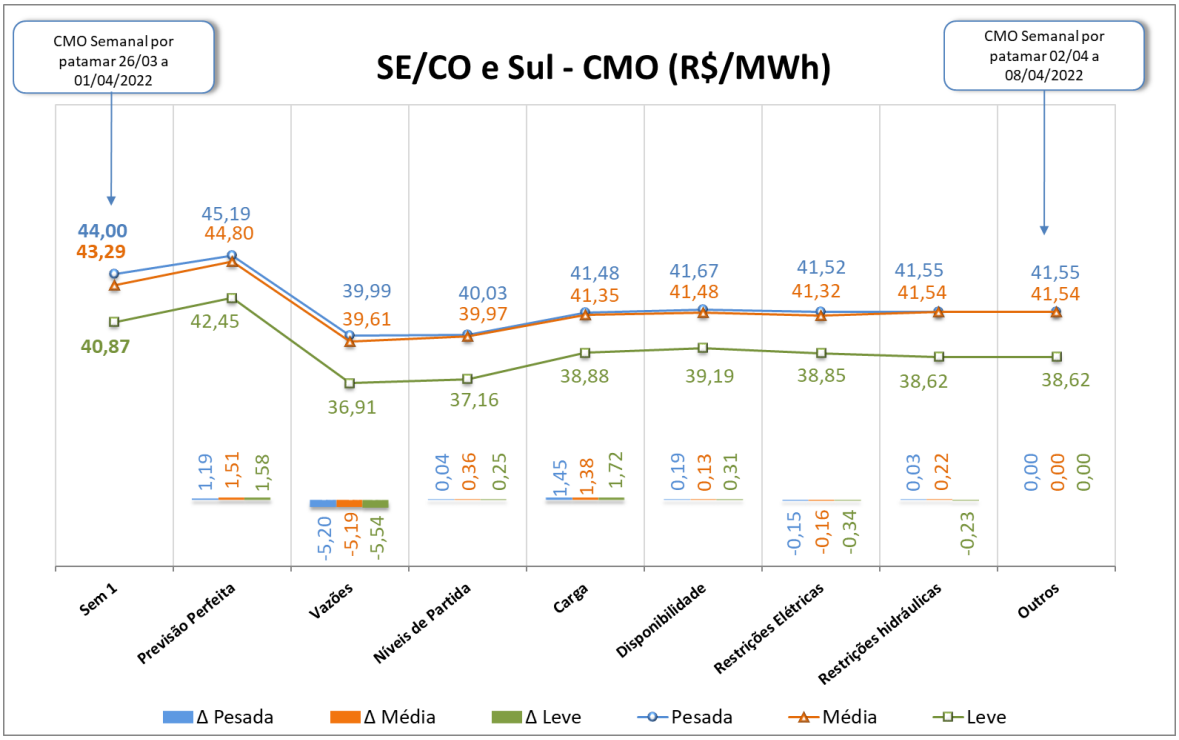

O conteúdo desta publicação foi produzido pelo ONS com base em dados e informações de conhecimento público. É de responsabilidade exclusiva dos agentes e demais interessados a obtenção de outros dados e informações, a realização de análises, estudos e avaliações para fins de tomada de decisões, definição de estratégias de atuação, assunção de compromissos e obrigações e quaisquer outras finalidades, em qualquer tempo e sob qualquer condição. É proibida a reprodução ou utilização total ou parcial do presente sem a identificação da fonte.

7. GERAÇÃO TÉRMICA

A Figura 4 apresenta, para cada subsistema, o despacho térmico por modalidade indicado pelo Decomp para a próxima semana operativa.

Figura 4 – Geração térmica para a próxima semana operativa

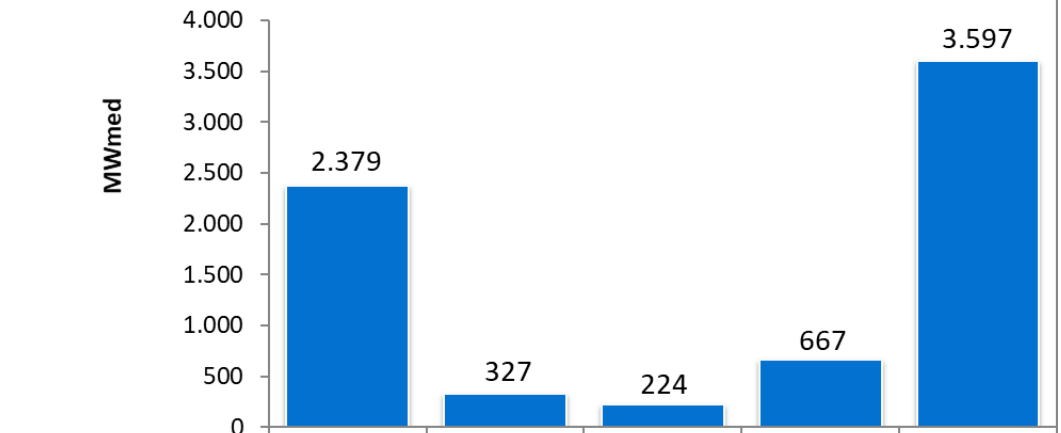

	SE/CO	SUL	NE	NORTE	SIN
RESTRIÇÃO ELÉTRICA	0	0	0	0	0
INFLEXIBILIDADE	2379	327	224	667	3597
ORDEM DE MÉRITO	0	0	0	0	0

Na tabela abaixo segue a Indicação de despacho antecipado por ordem de mérito de custo para a semana de 04/06/2022 a 10/06/2022.

Tabela 4 – UTEs com contrato de combustível GNL

UTE			Benefício (R$/MWh)		
Nome	Cod	CVU (R$/MWh)	Carga Pesada	Carga Média	Carga Leve
SANTA CRUZ	86	294,95	44,34 (2)	44,34 (2)	44,34 (2)
LUIZORMELO	15	454,19	44,34 (2)	44,34 (2)	44,34 (2)
PSERGIPE I	224	416,26	44,12 (2)	44,12 (2)	44,12 (2)

(1) Comandado o despacho antecipado por ordem de mérito de custo nesse patamar

(2) NÃO foi comandado o despacho antecipado por ordem de mérito de custo nesse patamar

Assim sendo, não há previsão de despacho antecipado por ordem de mérito de custo para as UTE Santa Cruz, Luiz O. R. Melo e Porto Sergipe I, para a semana de 04/06 a 10/06/2022.

O conteúdo desta publicação foi produzido pelo ONS com base em dados e informações de conhecimento público. É de responsabilidade exclusiva dos agentes e demais interessados a obtenção de outros dados e informações, a realização de análises, estudos e avaliações para fins de tomada de decisões, definição de estratégias de atuação, assunção de compromissos e obrigações e quaisquer outras finalidades, em qualquer tempo e sob qualquer condição. É proibida a reprodução ou utilização total ou parcial do presente sem a identificação da fonte.

8. IMPORTAÇÃO DE ENERGIA DA REPÚBLICA ORIENTAL DO URUGUAI

8.1. República Oriental do Uruguai

Para a próxima semana operativa, foi declarada apenas a seguinte oferta de importação de energia da República Oriental do Uruguai para o Sistema Interligado Nacional - SIN através da conversora de Melo (550 MW).

- **Enel**

Conforme declaração do agente, esta importação poderá ser realizada exclusivamente pela conversora Melo.

Tabela 5 – Energia ofertada para importação

	Oferta de Energia para a Semana de 02/04 a 08/04 (MWmed)					
	Bloco 1	Bloco 2	Bloco 3	Bloco 4	Bloco 5	Total
Carga Pesada	150	100	100	100	50	500
Carga Média	150	100	100	100	50	500
Carga Leve	150	100	100	100	50	500
CVU (R$/MWh)	474,31	1.245,55	1.406,84	1.925,30	2.259,41	

8.2. República da Argentina

Para esta semana operativa, não houve oferta de importação de energia da República da Argentina.

Nota: Detalhes sobre a importação de energia vide Portaria Nº 339, de 15 de Agosto de 2018 disponível em: http://pesquisa.in.gov.br/imprensa/jsp/visualiza/index.jsp?data=17/08/2018&jornal=515&pagina=60&totalArquivos=136

O conteúdo desta publicação foi produzido pelo ONS com base em dados e informações de conhecimento público. É de responsabilidade exclusiva dos agentes e demais interessados a obtenção de outros dados e informações, a realização de análises, estudos e avaliações para fins de tomada de decisões, definição de estratégias de atuação, assunção de compromissos e obrigações e quaisquer outras finalidades, em qualquer tempo e sob qualquer condição. É proibida a reprodução ou utilização total ou parcial do presente sem a identificação da fonte.

9. ARMAZENAMENTOS OPERATIVOS

Para uma melhor avaliação de diversos cenários hidrometeorológicos, notadamente, aqueles de curto prazo e suas influências nas previsões de vazões nos subsistemas, os resultados desta revisão do PMO contemplam cenários de afluências visando melhor representar a ocorrência de precipitação e, consequentemente, seus efeitos sobre as afluências e armazenamentos.

Além dos resultados associados ao valor esperado das previsões de afluências, as simulações operativas também foram realizadas com os limites superior e inferior das previsões de afluências. Apresentamos a seguir as correspondentes energias naturais afluentes e os resultados obtidos com a aplicação dos diferentes cenários de afluência.

Tabela 6 – Previsão de ENA dos cenários de sensibilidade

Subsistema	ENERGIAS NATURAIS AFLUENTES					
	Previsão Mensal					
	LI		VE		LS	
	(MWmed)	%MLT	(MWmed)	%MLT	(MWmed)	%MLT
SE/CO	34.131	**62**	39.973	**73**	45.742	**83**
Sul	5.408	**83**	9.054	**140**	12.651	**195**
Nordeste	4.662	**40**	5.699	**49**	6.734	**58**
Norte	26.297	**97**	28.701	**106**	31.101	**115**

Tabela 7 – Previsão de %EARmáx para o final do mês

Subsistema	% EARmáx 01/04	% EARmáx - 30/04		
	NÍVEL INICIAL	NÍVEL PMO		
	VE	LI	VE	LS
SE/CO	63,6	65,1	68,5	70,9
Sul	45,8	45,4	50,0	67,7
Nordeste	96,4	94,4	96,4	97,9
Norte	98,7	99,8	99,6	100,0

O conteúdo desta publicação foi produzido pelo ONS com base em dados e informações de conhecimento público. É de responsabilidade exclusiva dos agentes e demais interessados a obtenção de outros dados e informações, a realização de análises, estudos e avaliações para fins de tomada de decisões, definição de estratégias de atuação, assunção de compromissos e obrigações e quaisquer outras finalidades, em qualquer tempo e sob qualquer condição. É proibida a reprodução ou utilização total ou parcial do presente sem a identificação da fonte.

10. RESERVATÓRIOS EQUIVALENTES DE ENERGIA

A seguir são apresentadas as previsões de Energia Natural Afluente para a próxima semana operativa e para o mês de abril, bem como as previsões de Energia Armazenada nos Reservatórios Equivalentes de Energia – REE, desta revisão do PMO.

Tabela 8 – Previsão de ENA por REE

Valor Esperado das Energias Naturais Afluentes				
REE	Previsão Semanal		Previsão Mensal	
	02/04/2022 a 08/04/2022		abr/22	
	(MWmed)	%MLT	(MWmed)	%MLT
Sudeste	6.460	87	5.702	77
Madeira	7.868	67	7.005	60
Teles Pires	4.744	145	3.893	119
Itaipu	3.001	84	3.094	87
Paraná	18.249	68	16.423	62
Paranapanema	2.291	97	1.724	73
Sul	3.346	105	4.411	138
Iguaçu	3.880	118	4.643	141
Nordeste	7.387	64	5.699	49
Norte	13.530	93	11.630	80
Belo Monte	12.669	116	12.622	116
Manaus	2.942	194	3.405	224

Tabela 9 – Previsão de %EARmáx por REE

% Energia Armazenável Máxima		
REE	Previsão Semanal	Previsão Mensal
	08-abr	30-abr
	(%EARmáx)	(%EARmáx)
Sudeste	64,1	66,3
Madeira	100,0	98,2
Teles Pires	87,4	99,7
Itaipu	5,6	9,4
Paraná	66,9	70,7
Paranapanema	49,1	53,0
Sul	37,1	44,1
Iguaçu	52,1	55,2
Nordeste	95,9	96,4
Norte	100,0	100,0
Belo Monte	100,0	100,0
Manaus	99,4	93,4

O conteúdo desta publicação foi produzido pelo ONS com base em dados e informações de conhecimento público. É de responsabilidade exclusiva dos agentes e demais interessados a obtenção de outros dados e informações, a realização de análises, estudos e avaliações para fins de tomada de decisões, definição de estratégias de atuação, assunção de compromissos e obrigações e quaisquer outras finalidades, em qualquer tempo e sob qualquer condição. É proibida a reprodução ou utilização total ou parcial do presente sem a identificação da fonte.

11. DESPACHO TÉRMICO POR MODALIDADE, PATAMAR DE CARGA E USINA

Nas tabelas abaixo, a diferenciação entre geração por inflexibilidade e por ordem de mérito tem caráter informativo, com o objetivo de detalhar a informação de inflexibilidade enviada pelos respectivos agentes para esta revisão do PMO. Ressalta-se que nas etapas de Programação Diária e Tempo Real, o montante despachado nas usinas termelétricas indicadas por ordem de mérito é plenamente intitulado como ordem de mérito.

REGIÃO SUDESTE/CENTRO-OESTE																	
Térmicas Potência (MW)	Combustível	CVU (R$/MWh)	Inflexibilidade			Ordem de Mérito			Total Mérito e INFL.			Razão Elétrica			Total UTE		
			P	M	L	P	M	L	P	M	L	P	M	L	P	M	L
ATLAN_CSA (255)	Resíduos	0,00	137,0	137,0	137,0				137,0	137,0	137,0				137,0	137,0	137,0
W.ARJONA (177)*	Gás	---															
W.ARJONA O (177)*	Diesel	---															
ANGRA 2 (1350)	Nuclear	20,12	1350,0	1350,0	1350,0	0,0	0,0	0,0	1350,0	1350,0	1350,0				1350,0	1350,0	1350,0
ANGRA 1 (640)	Nuclear	31,17	640,0	640,0	640,0	0,0	0,0	0,0	640,0	640,0	640,0				640,0	640,0	640,0
NORTEFLU 1 (400)	Gás	97,34															
NORTEFLU 2 (100)	Gás	111,13															
O.PINTADA (50)	Biomassa	124,48	32,0	32,0	32,0				32,0	32,0	32,0				32,0	32,0	32,0
UTE STA VI (41)	Biomassa	134,46															
PREDILECTA (5)	Biomassa	175,91	1,0	1,0	1,0				1,0	1,0	1,0				1,0	1,0	1,0
ATLANTICO (235)	Resíduos	212,79	218,7	218,7	218,7				218,7	218,7	218,7				218,7	218,7	218,7
NORTEFLU 3 (200)	Gás	213,55															
BAIXADA FL (530)	Gás	290,92															
SANTA CRUZ (500)	GNL	294,95															
ST.CRUZ 34 (436)	Óleo	310,41															
T.LAGOAS (350)	Gás	316,26															
CUBATAO (216)	Gás	367,86															
TERMORIO (989)	Gás	376,38															
LUIZORMELO (204)	GNL	454,19															
SEROPEDICA (360)	Gás	464,83															
PIRAT.12 O (200)	Gás	470,34															
JUIZ DE FO (87)	Gás	522,96															
CUIABA CC (529)	Gás	570,07															
UTE GNA I (1338)	Gás	572,01															
NPIRATINGA (572)	Gás	654,42															
NORTEFLU 4 (127)	Gás	798,62															
T.MACAE (929)	Gás	880,49															
TNORTE 2 (349)	Óleo	910,86															
CAMPOS (25)	Gás	978,10															
VIANA (175)	Óleo	1257,47															
PALMEIR_GO (176)	Diesel	1492,83															
IBIRITE (226)	Gás	1496,82															
DAIA (44)	Diesel	1827,31															
GOIANIA 2 (140)	Diesel	1927,25															
XAVANTES (54)	Diesel	2631,53															
TOTAL SE/CO (12009)			2378,7	2378,7	2378,7	0,0	0,0	0,0	2378,7	2378,7	2378,7	0,0	0,0	0,0	2378,7	2378,7	2378,7

REGIÃO SUL																	
Térmicas Potência (MW)	Combustível	CVU (R$/MWh)	Inflexibilidade			Ordem de Mérito			Total Mérito e INFL.			Razão Elétrica			Total UTE		
			P	M	L	P	M	L	P	M	L	P	M	L	P	M	L
URUGUAIANA (640)	Gás	---															
PAMPA SUL (345)	Carvão	77,19															
CANDIOTA_3 (350)	Carvão	95,32	320,0	320,0	320,0				320,0	320,0	320,0				320,0	320,0	320,0
SAO SEPE (8)	Biomassa	97,11	5,0	5,0	5,0				5,0	5,0	5,0				5,0	5,0	5,0
J.LACER. C (363)	Carvão	229,27															
J.LACER. B (262)	Carvão	271,21															
J.LAC. A2 (132)	Carvão	278,38															
J.LAC. A1 (100)	Carvão	304,61															
MADEIRA (4)	Biomassa	342,65	2,0	2,0	2,0				2,0	2,0	2,0				2,0	2,0	2,0
FIGUEIRA (20)	Carvão	475,68															
CANOAS (249)	Diesel	698,14															
ARAUCARIA (484)	Gás	706,35															
TOTAL SUL (2957)			327,0	327,0	327,0	0,0	0,0	0,0	327,0	327,0	327,0	0,0	0,0	0,0	327,0	327,0	327,0

*Conforme Resolução Autorizativa ANEEL nº 10.422/2021, a UTE William Arjona pode operar com óleo diesel, como combustível alternativo.

O conteúdo desta publicação foi produzido pelo ONS com base em dados e informações de conhecimento público. É de responsabilidade exclusiva dos agentes e demais interessados a obtenção de outros dados e informações, a realização de análises, estudos e avaliações para fins de tomada de decisões, definição de estratégias de atuação, assunção de compromissos e obrigações e quaisquer outras finalidades, em qualquer tempo e sob qualquer condição. É proibida a reprodução ou utilização total ou parcial do presente sem a identificação da fonte.

REGIÃO NORDESTE

Térmicas Potência (MW)	Combustível	CVU (R$/MWh)	Inflexibilidade			Ordem de Mérito			Total Mérito e INFL.			Razão Elétrica			Total UTE		
			P	M	L	P	M	L	P	M	L	P	M	L	P	M	L
ALTOS (13)	Diesel	0,00															
ARACATI (11)	Diesel	0,00															
BATURITE (11)	Diesel	0,00															
C.MAIOR (13)	Diesel	0,00															
CAUCAIA (15)	Diesel	0,00															
CRATO (13)	Diesel	0,00															
IGUATU (15)	Diesel	0,00															
JUAZEIRO N (15)	Diesel	0,00															
MARAMBAIA (13)	Diesel	0,00															
NAZARIA (13)	Diesel	0,00															
PECEM (15)	Diesel	0,00															
ERB CANDEI (17)	Biomassa	97,18	4,5	4,5	4,5				4,5	4,5	4,5				4,5	4,5	4,5
PROSPERIDA (28)	Gás	183,28															
TERMOPE (533)	Gás	198,55															
FORTALEZA (327)	Gás	254,96															
T.BAHIA (186)	Gás	374,87	110,0	110,0	110,0				110,0	110,0	110,0				110,0	110,0	110,0
PSERGIPE I (1593)	GNL	416,26															
VALE ACU (368)	Gás	450,86	110,0	110,0	110,0				110,0	110,0	110,0				110,0	110,0	110,0
TERMOCEARA (223)	Gás	474,09															
SYKUE I (30)	Biomassa	510,12															
P.PECEM2 (365)	Carvão	574,14															
P.PECEM1 (720)	Carvão	583,03															
PERNAMBU_3 (201)	Óleo	1090,09															
MARACANAU (168)	Óleo	1226,76															
TERMOCABO (50)	Óleo	1241,89															
TERMONE (171)	Óleo	1244,02															
TERMOPB (171)	Óleo	1244,02															
CAMPINA_GR (169)	Óleo	1257,49															
SUAPE II (381)	Óleo	1294,50															
GLOBAL I (149)	Óleo	1423,80															
GLOBAL II (149)	Óleo	1423,80															
CURUMIM (31)	Óleo	1490,44															
APOENA (147)	Óleo	1835,79															
GUARANI (150)	Óleo	1835,79															
PETROLINA (136)	Óleo	2014,11															
POTIGUAR_3 (66)	Diesel	2031,38															
POTIGUAR (53)	Diesel	2031,40															
PAU FERRO (94)	Diesel	2275,62															
TERMOMANAU (143)	Diesel	2275,62															
TOTAL NE (6966)			224,5	224,5	224,5	0,0	0,0	0,0	224,5	224,5	224,5	0,0	0,0	0,0	224,5	224,5	224,5

REGIÃO NORTE

Térmicas Potência (MW)	Combustível	CVU (R$/MWh)	Inflexibilidade			Ordem de Mérito			Total Mérito e INFL.			Razão Elétrica			Total UTE		
			P	M	L	P	M	L	P	M	L	P	M	L	P	M	L
C. ROCHA (85)	Gás	0,00	65,0	65,0	65,0				65,0	65,0	65,0				65,0	65,0	65,0
JARAQUI (75)	Gás	0,00	63,0	63,0	63,0				63,0	63,0	63,0				63,0	63,0	63,0
MANAUARA (67)	Gás	0,00	64,0	64,0	64,0				64,0	64,0	64,0				64,0	64,0	64,0
PONTA NEGR (73)	Gás	0,00	64,0	64,0	64,0				64,0	64,0	64,0				64,0	64,0	64,0
TAMBAQUI (93)	Gás	0,00	63,0	63,0	63,0				63,0	63,0	63,0				63,0	63,0	63,0
MARANHAO3 (519)	Gás	94,86															
APARECIDA (166)	Gás	134,62	75,0	75,0	75,0				75,0	75,0	75,0				75,0	75,0	75,0
UTE MAUA 3 (591)	Gás	134,62	264,0	264,0	264,0				264,0	264,0	264,0				264,0	264,0	264,0
PARNAIB_IV (56)	Gás	151,69															
N.VEN2_L22 (27)	Gás	257,06															
N.VEN2_L7 (151)	Gás	257,06															
MARAN_VL_7 (336)	Gás	270,73															
MARANIVL_7 (336)	Gás	270,73	10,0	18,0	5,0				10,0	18,0	5,0				10,0	18,0	5,0
MARAN_VL22 (1)	Gás	270,74															
MARANIVL22 (1)	Gás	270,74															
P. ITAQUI (360)	Carvão	565,94															
GERAMAR1 (166)	Óleo	1257,44															
GERAMAR2 (166)	Óleo	1257,44															
TOTAL NORTE (3271)			668,0	676,0	663,0	0,0	0,0	0,0	668,0	676,0	663,0	0,0	0,0	0,0	668,0	676,0	663,0

O conteúdo desta publicação foi produzido pelo ONS com base em dados e informações de conhecimento público. É de responsabilidade exclusiva dos agentes e demais interessados a obtenção de outros dados e informações, a realização de análises, estudos e avaliações para fins de tomada de decisões, definição de estratégias de atuação, assunção de compromissos e obrigações e quaisquer outras finalidades, em qualquer tempo e sob qualquer condição. É proibida a reprodução ou utilização total ou parcial do presente sem a identificação da fonte.